Tenda

sua próxima conquista

Book de Lançamento

Regional: SP

Projeto: Dália

Data Comitê: 15.09.2025

One Page – Dália- Real

[1]

Cidade	São Paulo	Mancha de demanda	SP - SZS1 - São Paulo Sul 1
Regional	SP	Cluster MPR	1 - Vermelho
Cenário de Aprovação	Real	Tipo de Aprovação	Consolidado
Fase Anterior	N/A		
Tipo de Comitê	Lançamento	Versão da VF	Versão 1.0: Set

Unidades (Fases)	667 (1)	CA Máx | Proj	4,4 | 2,4
Unidades com Vaga (%)	0 (0%)	Escritura | Lançamento	mar/19 | set/25
Unidades com Varandas (%)	150 (22,5%)	Tipologia	F2E Plus - CDW

[2]

Valor Líquido do Terreno (% VGV)	6.967 (4,3%)	Un. Perm. Fís (% Ter)	4 (14,1%)
Cash (Correção)	5.986 (N/A)	%VGV Perm Fin Líquida (% Ter)	0,0% (0,0%)
Valor R$/m²	1.351	VAR (%VGV)	000 (0,0%)

[3]

Custo Construção (%VGV)	73.900 (45,5%)	Indireto Unit.	19.449
Prazo da Obra (meses)	28	Torre Unit.	64.574
Custo Total Unit. (LPU):	110.794 (94)	Infra Unit.	11.646
Início de Obra	jun-26	Fundação Unit.	8.632

[4]

Preço Nominal Unit.	243.431	VSO	37
Preço Raso Unit.	227.596	Referência	VISION
Avaliação Unit.	275.172	Renda (% em RET 1%)	3.399 (25,0%)

Fase de Lançamento - Uso exclusivo para o Ciclo Financeiro		Preço Raso Inf. Médio Unit.	232.228
Preço Inf. Médio Unit.	248.368	Margem Bruta REF (%)	41,3%
Custo Inf. Médio Unit.	145.766	Margem Rasa REF (%)	37,2%

[5]

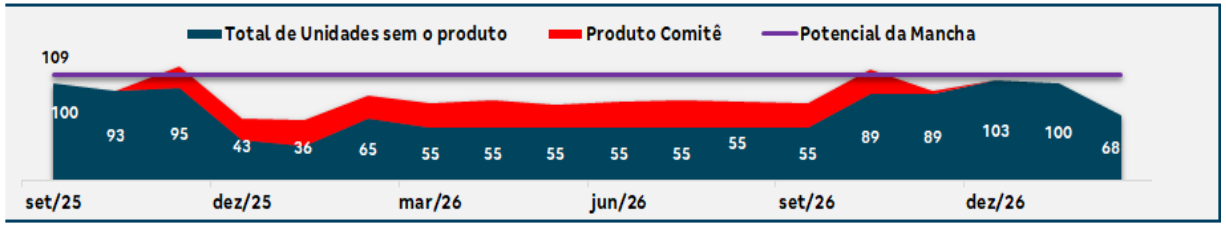

LI (Régua):	5,3% (20,0%)	Margem Bruta Econômica:	38,0%
LI Marginal:	27,9%	Margem Rasa Econômica:	33,0%
Margem Bruta REF:	41,3%	Margem Contribuição Econômica:	26,6%
Margem Rasa REF:	37,2%	Exposição (% VGV):	19.378 (12,0%)
TIR:	22,4%	VGV Total:	162.368
Payback Contingente (21 m) :	23 m/ (2 m)	Ger. Caixa 12 meses (R$):	(7.743)
Payback Consolidado:	23	Ger. Caixa 24 meses (R$):	12.048

Destaques

[1] Projeto:

1.1. Cond único, 2 blocos T+25 (tipologia nova 3.0 CDW), total de 667 Uhs, sendo 150 com varanda (22%). Atributos incorporados ao projeto: quadra, complexo de lazer com churrasqueiras integradas ao salão de festas. Melhoria de projeto aos clientes contemplando solução adicional de elevador para acesso da rua em função do desnível.

1.2 Área bruta do terreno é 11.047m², sendo 1.976m² desmembrados e não incorporado. Área remanescente incorporada de 9.071m², sendo 3.913m² (43%) de APP. Projeto desconsidera área desmembrada devido a incompatibilidade técnica, restrição de zoneamento e impossibilidade de demolição do galpão existente.

[2] Condições de pagamento do terreno:

2.1. Terreno "legado" escriturado em nov/20 por 5.9,MM, sendo 88% em cash (quitado em mai/2021) e 12% em permuta física no empreendimento, cravado em 4 unidades;

- Permuta física: 04 unid equivalente a 0.98M no valor nominal atual;

OBS: A área desmembrada com o galpão, será colocada a venda pelo preço de aproximadamente 1,5MM porém devido a dúvida de liquidez, não está contemplado na viabilidade qualquer receita desta venda. Tentamos durante 6 meses negociar com o vendedor diferentes formas de fazermos permuta desta área desmembrada com as 4 unidades, mas não tivemos êxito.

[3] Custo de construção:

3.1. Custo total R$ 110.794, sendo R$ 107.343 referente ao custo I, R$2.826 de infra (~45% de rateio já executado pelo projeto Tenda Vizinho Hortência), e R$625 de incorridos não aproveitados, decorrentes de outros 2 EPs anteriores.

3.2. Pró soluto atingindo de 36 meses, em função de folga de inicio de 9 m para inicio da obra devido à disponibilidade da fábrica, prazo de pré-forma de 7,7m em função de complexidade de contenções (parecer logística) e pós forma de 13m para término das obras de acesso;

[4] Preço de venda:

4.1. Pela localização borda da ZS em mancha e localização inferior ao projeto referência Vila Belezas, o preço e a renda do Dália foram ajustados para patamares inferiores;

4.2. Não foi mapeado concorrentes compatíveis na região, logo ciclo vislumbra grande potencial de demanda e ganho de preço.

[5] Resultado:

5.1 Visão real entrega MR REF de 37,2 e MB REF de 41,3%.

*Valores em R$ '000

One Page – Dália– Aprovação em Fundamento

Cidade	São Paulo	Mancha de demanda	SP - SZS1 - São Paulo Sul 1
Regional	SP	Cluster MPR	1 - Vermelho
Cenário de Aprovação	Aprovação em Fundamento	Tipo de Aprovação	Consolidado
Fase Anterior	N/A		
Tipo de Comitê	Lançamento	Versão da VF	Versão 1.0: Set

Unidades (Fases)	667 (1)	CA Máx | Proj	4,4 | 2,4
Unidades com Vaga (%)	0 (0%)	Escritura | Lançamento	jul/25 | set/25
Unidades com Varandas (%)	150 (22,5%)	Tipologia	F2E Plus - CDW

[2]

Valor Líquido do Terreno (% VGV)	12.127 (7,5%)	Un. Perm. Fís (% Ter)	0 (0,0%)
Cash (Correção)	0 (N/A)	%VGV Perm Fin Líquida (% Ter)	7,5% (100,0%)
Valor R$/m²	2.351	VAR (%VGV)	000 (0,0%)

[3]

Custo Construção (%VGV)	72.617 (45,0%)	Indireto Unit.	19.449
Prazo da Obra (meses)	28	Torre Unit.	64.574
Custo Total Unit. (LPU):	108.871 (94)	Infra Unit.	11.646
Início de Obra	mar-26	Fundação Unit.	8.632

[4]

Preço Nominal Unit.	242.119	VSO	37
Preço Raso Unit.	224.430	Referência	VISION
Avaliação Unit.	275.172	Renda (% em RET 1%)	3.399 (25,0%)



[5]

LI (Régua):	20,3% (20,0%)	Margem Bruta Econômica:	37,4%
LI Marginal:	20,3%	Margem Rasa Econômica:	31,6%
Margem Bruta REF:	40,8%	Margem Contribuição Econômica:	25,9%
Margem Rasa REF:	36,1%	Exposição (% VGV):	10.638 (6,6%)
TIR:	161,7%	VGV Total:	161.494
Payback Contingente (21 m) :	20 m/ (-1 m)	Ger. Caixa 12 meses (R$):	(9.515)
Payback Consolidado:	20	Ger. Caixa 24 meses (R$):	13.335

Destaques

[1] Incorridos visão fundamento:

1.1. Desconsidera R$ 625/uh de incorridos não aproveitados decorrentes de projetos anteriores;

1.2. Desconsidera R$ 1298/uh decorrente do custo da infra-externa já executada anteriormente durante a obra do empreendimento Hortência- croqui de infra executada x a executar no slide 16.

[2] Condições de pagamento do terreno:

2.1. Foi realizada uma análise comparativa de mercado, considerando propostas efetivas dos últimos seis meses em um raio de 3 km da região em questão, a qual aponta um valor médio de R$ 2.351/m² (vide slide 04); OBS: não há referência de proposta para compra deste terreno, pois este landbank nunca foi ofertado à mercado.

2.2. Considerado pagamento em permuta financeira na VF.

OBS: apenas como referência, em nov2024 aprovamos o empreendimento Vila das Belezas (referência na ZS) na visão fundamento com custo de terreno de R$ 1.954/m2 e fração de 6,8%.

[3] Custos de construção e Incorporação Fundamento:

- Custo total de construção em R$ 108.871;
- R$ 107.343 referente ao custo I;
- R$ 1.528 referente ao custo II - descontando as "extensões executadas" (slide 15 folha rosto)

[4] Preço de venda:

4.1. Se mantém consideração do cenário real, com redução de 3 meses de PSOL, devido à folga de inicio na regra ouro (6 meses).

*Valores em R$ '000

Dália– Aprovação em Fundamento

1. Base de propostas do raio de 3km do Dália nos últimos 6 meses:

Os terrenos utilizados como base de referência de preço foram selecionados devido à proximidade do Dália, dentro do raio de 3km. Com destaque que não possuem nenhuma restrição ambiental que prejudique o adensamento do terreno.

Terreno (base prospec)	Terreno	Área Terreno (m²)	Valor Oferta	R$/M²
RUA PASTOR JERÔNIMO GRANERO GARCIA	A	4.000	R$ 8.000.000	2.000
RUA LUZIA PINHATTA ANDREATTI	B	8.259	R$ 12.000.000	1.453
ESTRADA M BOI	C	2.000	R$ 6.500.000	3.250
			MÉDIA	**R$ 2.351**

2. Avaliação Comparativa dos Terrenos:

Terreno A: Descartado devido à inviabilidade técnica de drenagem; **Terreno B:** Desconsiderado por enquanto pois o proprietário exige início do fluxo de pagamento desvinculado da aprovação, além de estar em processo de regularização de inventário; **Terreno C:** Descartado pelo tamanho.

3. Definição da Proposta de Valor para o Dália:

Considera que a área do terreno foi comprometida pela alta incidência de APP (aprox.43%), reduzindo o potencial de aproveitamento total do lote. Assim, o valor proposto foi calculado com base no preço do metro quadrado da área líquida com este desconto de APP conforme o projeto aprovado (slide 8).

EMPREENDIMENTO	Área Terreno (m²)	Valor Proposta	R$/M²
DALIA	5.157	R$ 12.126.583	2.351

*Valores em R$ '000

- Pareceres
- Análise da Mancha e Implantação
- Operações
- Inteligência de Mercado
- Financeiro

Farol Pareceres

Área	Riscos Associados	Parecer	Criticidade
Jurídico	Pela documentação analisada até o presente momento, não se verificam apontamentos relevantes que tragam impacto no registro da incorporação. Pendente aprovação do projeto e dispensa do Graprohab.	Ok	
Legalização	Terreno não contaminado. Não foram identificados riscos associados ao lançamento do empreendimento.	Ok	
Produto	n/a	Ok	
GETEC	Possuímos descarte irregular de esgoto dos vizinhos dentro do nosso terreno. Faremos a captaçõ deste descarte em uma rede isolada, porém a SABESP não aceita ser responsável pela manutenção destas redes. Será necessário informar ao condomínio a existência da rede coletora dos vizinhos dentro do empreendimento.	Ok, com ressalvas	
Logística	Obrigatório concretagem pelo viário público e uso da calçada até a entrega da obra.	Ok	
Contratação	**Laudo de engenharia:** Ainda não há laudo de engenharia, ofício respondido no começo de setembro, aguardando retorno. Data de laudo com pendências: 26/09. Data de laudo sem pendências: 07/10/2025 **Risco:** Pendente - Dependente do Laudo de Engenharia. **Jurídico:** Pendente RI - Previsão de emissão em 30/09. Com base nessa data, a conclusão da análise jurídica está estimada para 10/10/2025.	Ok	
Inteligência de mercado	IM avalia o Preço Vision como factível.	Ok	
Comercial/Ciclo	O Ciclo avaliou o preço e o VSO como factíveis. O projeto está localizado em uma região estratégica na zona Sul e com grande potencial de demanda, sem concorrentes diretos.	Ok	
Estudos Econômicos	Cenário Aprovação em fundamento, necessita de validação da Diretoria	Ok, com ressalvas	

Pareceres

Análise da Mancha e Implantação

Operações

Inteligência de Mercado

Financeiro

PRODUTO

Empreendimento Dália
Escritura | Lançamento

Informações Gerais – Condomínio Único

Terreno	Área terreno	9070,81m²	
	Menor poligonal	9070,81m²	
	App/fna	3913,43m² | 666,61m²	
	Reserva de calçada/ melhoramento víario	Sim/Sim	
	Área liquida	5.157,38m²	
Diretrizes Urbanísticas	Zoneamento	Zeis 1	
	Ca máximo	4,50	Zona: 2,50
			Cota: 0,75 (30%)
			Incentivo HIS1: 1,25 (50%)
	CA liquido	4,24	
	Ca projetado	2,42	
	Gabarito máximo	N.A.	
Geral	Total uh	667	
	Total de vagas exigido	0 (0%)	
	Total de vagas projetado	1 (C/D)	
Tipologia	Tipologia	SP-0200-LF-CD15-CE1A (CDW)	
	Gabarito	T+25	
	Lâmina	01 x 12PP e 01 x 14PP	
	Área privativa	32,81m² e 32,44m²	
	Varanda	150 uh (22%)	
Condomínio	Unidade pcd	21	
	Unidade lazer | técnica	07 | 02	
	Torre	02	
	Fase	00	
Lazer	Lazer Interno	1 - Salão de Festas com Churrasqueira, 2 – Churrasqueira Gourmet, 3 – Espaço Teen, 4 - Salão de Festas, 5 - Brinquedoteca, 6 - Fitness, 7 -Espaço Delivery, 8 - Sport Bar, 9 - Espaço Office	
	Lazer Externo	10 - Play Kids, 11 - Play Baby, 12 - Play Pet, 13 - Praça de Convívio, 14 – Praça de Chegada, 15 – Quadra Descoberta, 16 – Praça de Jogos, 17 – Multipla Estação	

Desconsiderando a área de APP o CA sobre a área líquida é 4,24, enquanto o CA sobre a área total da poligonal corresponde a 2,42.

PRODUTO

Empreendimento Dália
Escritura | Lançamento

	Descrição	Criticidade	Observação
Usabilidade	**Acesso Empreendimento**		Desnível de 6,40m solucionado com escada com 37 degraus e elevador
	Percurso do pedestre até torre		
Diferencial produto	**Faixa de renda**	2	
	Prime	Não	
	Supercondomínio	Não	
	Atributos Infra	Sim	Quadra descoberta
	Atributos Torre	Sim	Varanda
	Edifício Garagem	Não	

Imagem meramente ilustrativa do empreendimento
Bosque Jacarepaguá - RJ

Empreendimento Dália
Escritura | Lançamento

667 UH (SENDO 21 UNIDADES ACESSÍVEIS) – 1 VAGA (C/D)				
Módulo	**Blocos**	**UH**	**Vagas**	**Parecer**
Módulo 01	01 Bloco (T+25)	307 UH (SENDO 9 U. A.)	1 VAGA (C/D)	Dos lazeres, estão contemplados no módulo 01 o Salão de Festas com Churrasqueira, Churrasqueira Gourmet, Praça de Convívio, Play Pet, Play baby, Play Kids, Praça de Jogos e Quadra Descoberta. Demais lazeres que não estão contemplados neste módulo, necessário inclusão dessa informação no RI e material de vendas.
Módulo 02	01 Bloco (T+25)	360 UH (SENDO 12 U. A.)	-	-

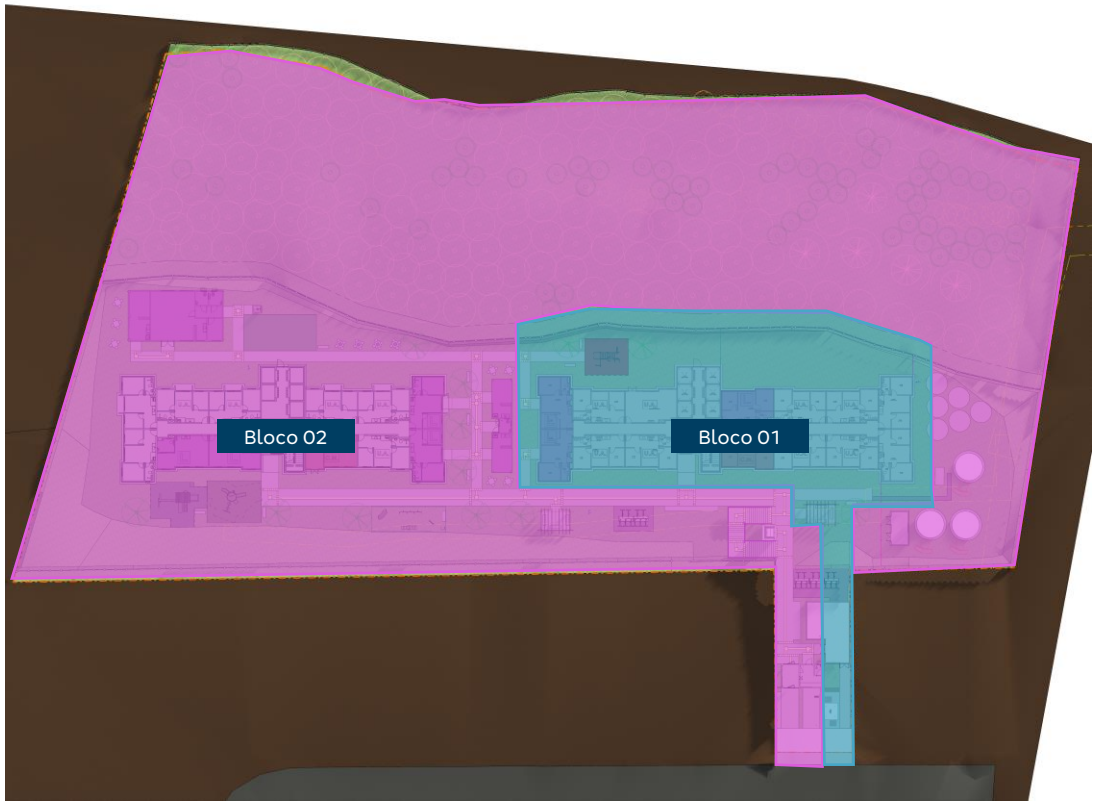

Mancha de Demanda

MANCHAS DE DEMANDA
- SZS – São Paulo Sul

Lançamento
1. V. Vila das Belezas

LandBank
2. Moove Santo Amaro
3. Essência do Campo
4. Dália
5. Moove Santo Amaro

Cluster MPR – (Comitê)

Cluster 1 - Vermelho

Região

Borda

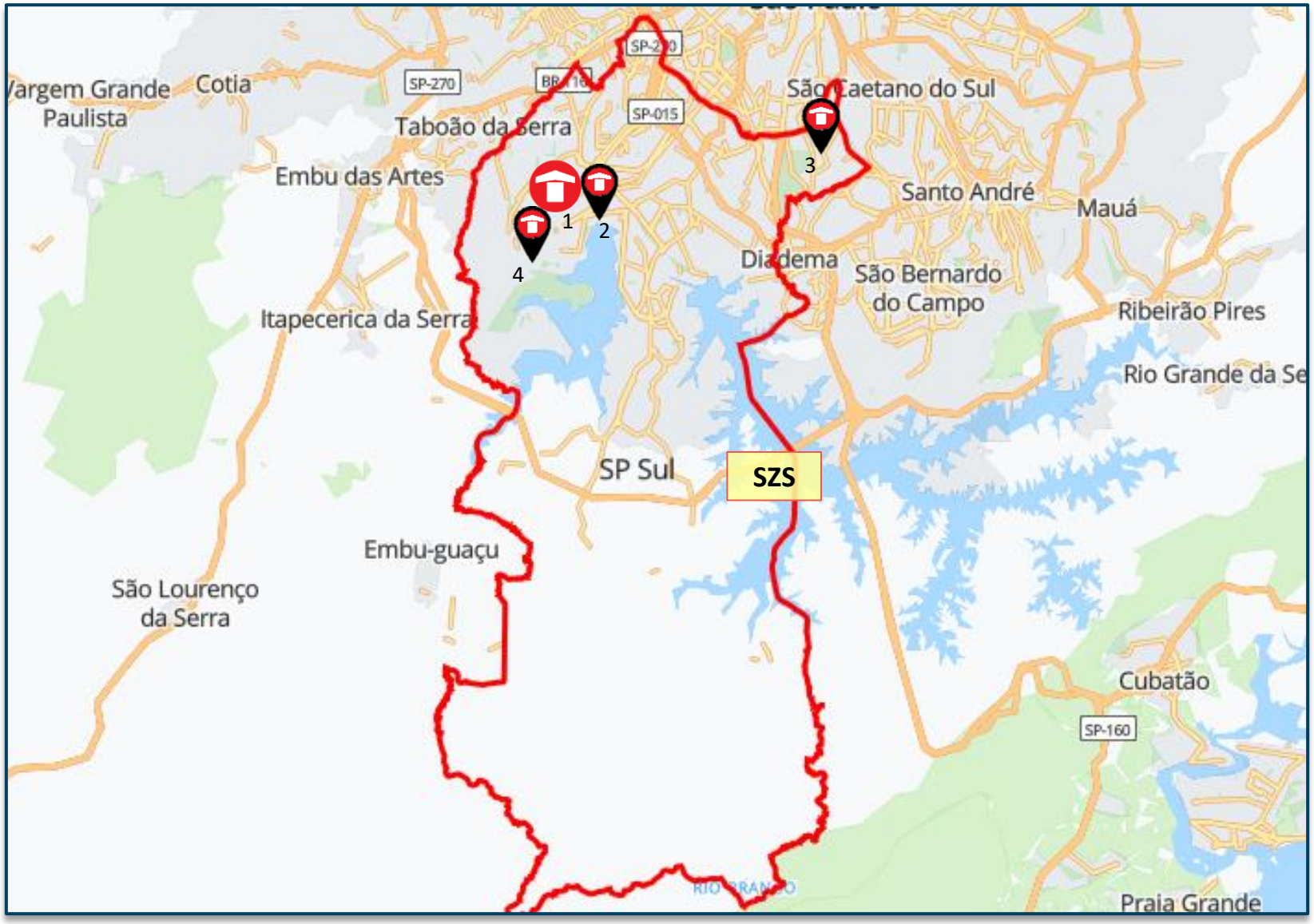

Lançados *LandBank* *Comitê*

Pareceres

Análise da Mancha e Implantação

Operações

Inteligência de Mercado

Financeiro

Implantação

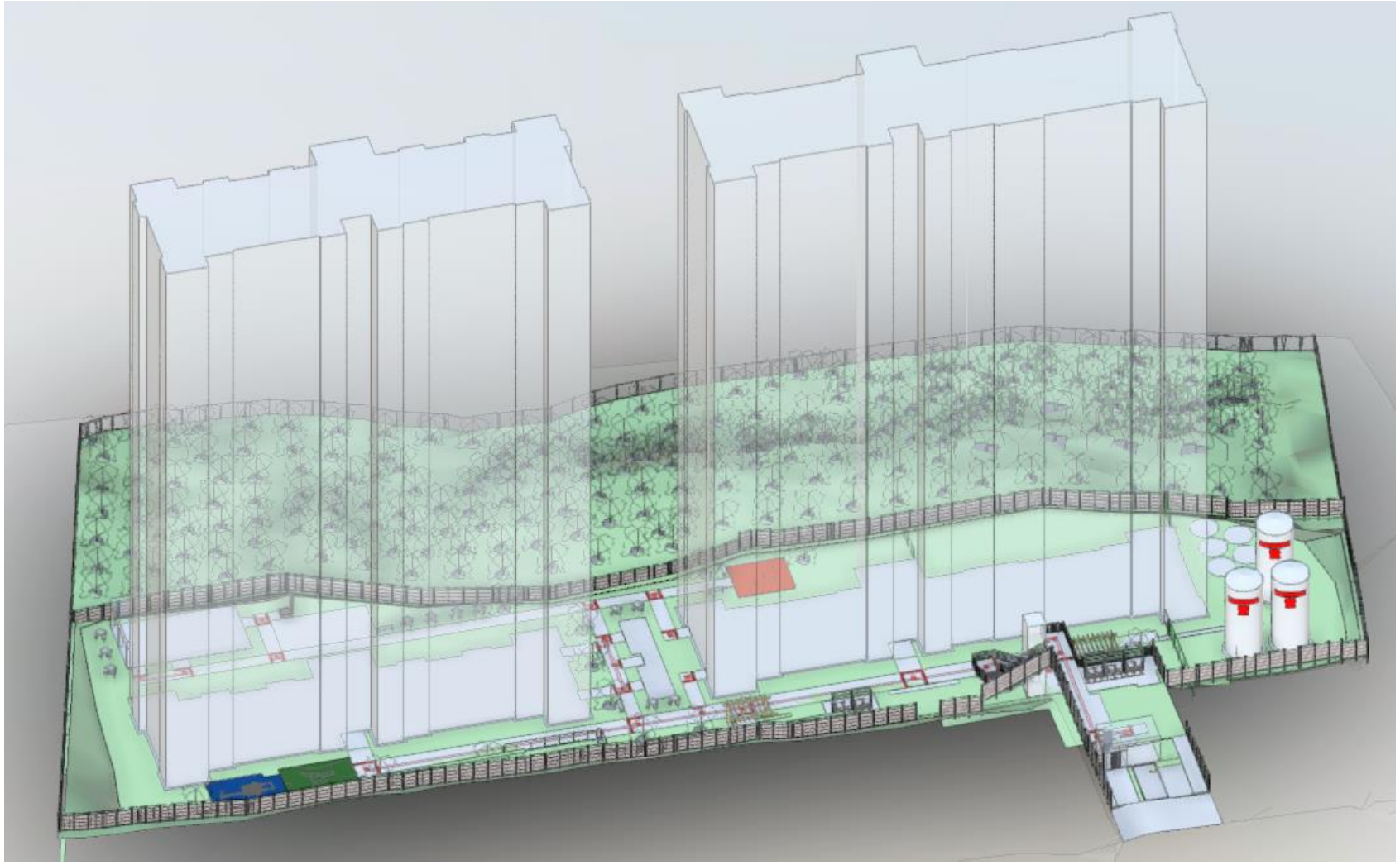

DÁLIA

1 Torre 12PP | T+25
1 Torre 14PP | T+25

676 Unid. A Construir
667 Unid. A Vender

ATRIBUTOS

Varandas
Quadra Poliesportiva

Custo de Construção

	DÁLIA R12	DÁLIA 21 PARAMETRIZAÇÃO	PQ. LIMÃO LVS
Torres	2	2	2
Unidades Construídas	676	676	644
Unidades Vendidas	667	667	634
Cidade	São Paulo - SP	São Paulo - SP	São Paulo - SP
Produto / Selo	F2EPlus - V0200 CDW	F2EPlus - V0200 CDW	SP-F2E Plus-CDW
Tipologia	1 Torre | T+25 | 12PP	1 Torre | T+25 | 12PP	1 Torre | 14PP | T+22
Tipologia	1 Torre | T+25 | 14PP	1 Torre | T+25 | 14PP	1 Torre | 14PP | T+22
Atributos	150 Varandas		
Projeto Infra	EP	AP	
Projeto Torre	EP	AP/EM	
Mês Base	setembro-25	outubro-24	julho-25
Incc	1.210,471	1.141,398	
LVS	julho-25	agosto-24	
Indiretos	julho-25	agosto-24	
Base de Preço	LPU 94	LPU 83	
Takt	2x2	2x2	
Prazo (mês)	28	29	24
CUSTO TOTAL I	R$ / UND R$ 107.343	R$ / UND R$ 102.939	R$ / UND R$ 102.428
Indireto	R$ 19.449	R$ 19.233	R$ 18.999
Torre	R$ 64.574	R$ 62.375	R$ 64.665
Infra	R$ 11.646	R$ 13.096	R$ 10.482
Fundação	R$ 8.632	R$ 6.802	R$ 7.564
EEE			
ETE			
Contenção	R$ 2.359	R$ 955	R$ 90
Terraplenagem	R$ 683	R$ 479	R$ 628
CUSTO TOTAL II	R$ 2.826	R$ 3.602	
Extensões Executadas	R$ 1.298		
Drenagem	R$ 1.036	R$ 1.809	
Extensão de Rede Elétrica	R$ 225	R$ 217	
Extensão de Rede Hidráulica	R$ 267	R$ 1.576	
CUSTO TOTAL III	R$ 625	R$ 625	
Incorridos	R$ 625	R$ 625	
CUSTO TOTAL IV			
Aprendizado			
CUSTO TOTAL IV		R$ 6.161	
Atualização por INCC		R$ 6.161	
CUSTO TOTAL I+II	R$ 110.169	R$ 101.809	R$ 102.428
CUSTO TOTAL I AO IV	R$ 110.794	R$ 113.328	R$ 102.428

Custo de Construção

	DÁLIA R12	DÁLIA 21 PARAMETRIZAÇÃO	
Torres	2	2	
Unidades Construídas	676	676	
Unidades Vendidas	667	667	
Condomínios (qta.)	1	1	
Cidade	São Paulo - SP	São Paulo - SP	
Produto / Selo	F2EPlus - V0200 CDW	F2EPlus - V0200 CDW	
Tipologia	1 Torre | T+25 | 12PP	1 Torre | T+25 | 12PP	
Tipologia	1 Torre | T+25 | 14PP	1 Torre | T+25 | 14PP	
Atributos	150 Varandas		
Projeto Infra	EP	AP	
Projeto Torre	EP	AP/EM	
Mês Base	setembro-25	outubro-24	
Incc	1210,471	1141,398	
LVS	julho-25	agosto-24	
Indiretos	julho-25	agosto-24	
Base de Preço	LPU 94	LPU 83	
Takt	2x2	2x2	
Prazo (mês)	28	29	
CUSTO TOTAL I	R$ / UND R$ 107.343	R$ / UND R$ 102.939	DIF R$ 4.404
Indireto	R$ 19.449	R$ 19.233	R$ 216
Torre	R$ 64.574	R$ 62.375	R$ 2.200
Infra	R$ 11.646	R$ 13.096	-R$ 1.450
Fundação	R$ 8.632	R$ 6.802	R$ 1.830
EEE	R$ 0	R$ 0	R$ 0
ETE	R$ 0	R$ 0	R$ 0
Contenção	R$ 2.359	R$ 955	R$ 1.404
Terraplenagem	R$ 683	R$ 479	R$ 204
CUSTO TOTAL II	R$ 2.826	R$ 3.602	-R$ 776
Extensões Executadas	R$ 1.298	R$ 0	R$ 1.298
Drenagem	R$ 1.036	R$ 1.809	-R$ 773
Extensão de Rede Elétrica	R$ 225	R$ 217	R$ 7
Extensão de Rede Hidráulica	R$ 267	R$ 1.576	-R$ 1.309
CUSTO TOTAL III	R$ 625	R$ 625	
Incorridos	R$ 625	R$ 625	R$ 0
CUSTO TOTAL IV	R$ 0	R$ 0	
Aterro Pré Carga	R$ 0	R$ 0	R$ 0
CUSTO TOTAL IV	R$ 0	R$ 6.161	
Atualização por INCC	R$ 0	R$ 6.161	-R$ 6.161
CUSTO TOTAL	R$ 110.794	R$ 113.328	-R$ 2.534

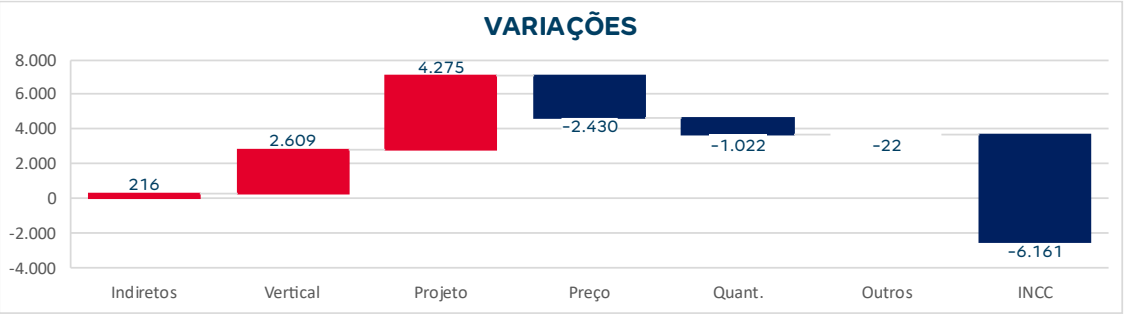

INDIRETOS
+325 | Caçambas

VERTICAL
+2.609 | Retroalimentação (Dissídio + QLP)

PROJETO
+2.110 | Estrutura Torre
+1.701 | Fundação
+1.350: Lajão (+730 Trincheira | +366 Concreto | +150 MO)
+351: ZF Solos | 403 Estacas Hélice - Pré: Ø60, Ø70 e Ø90
Input Rodolfo | 204 Estacas Hélice - Param: Ø60, Ø70 e Ø80
+1.404 | Contenção
+574 | Varanda
+143 | Shaft Hall
-700 | Elevador
-561 | Reservatório Met. x Fibra
-303 | Anexos
+204 | Terraplenagem
-153 | Extensão de esgoto (diretriz)

PREÇO
-2.164 | Elevador
-252 | Anexos
-92 | Muro de Divisa
+321 | Esq. Madeira
-480 | Extensão de Drenagem (cotação 07/2025)
-151| Extensão de Rede Hidráulica (cotação 07/2025)

QUANTIDADE
-184 | Sanca do Hall
-838 | Bombas do Reservatório

OUTROS
+900 | Inst. Infra (522 referente esgoto vizinho)
-347 | Suportes do Elevador

INCC
-6.161 | Atualização INCC

Operações

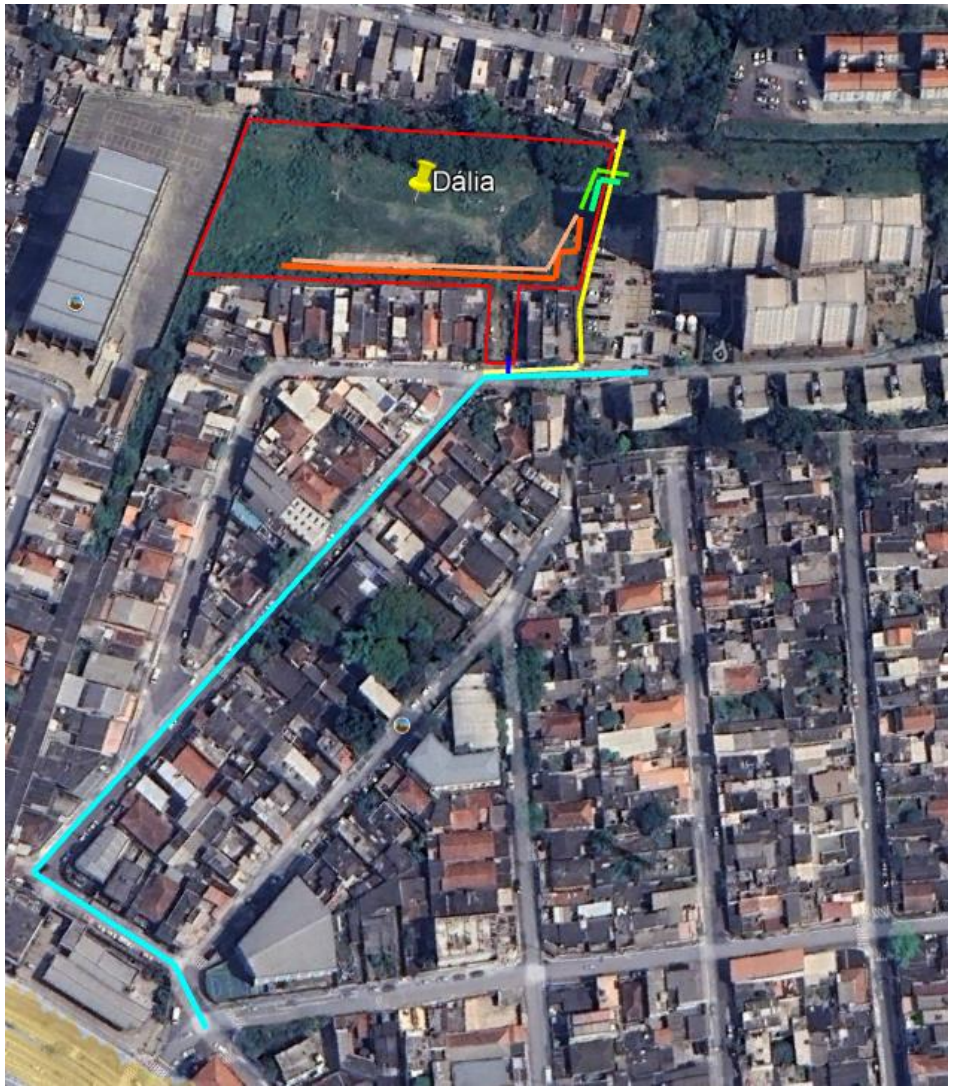

SISTEMA DE ABASTECIMENTO DE ÁGUA
316m de extensão de água até a Rua Henri Martins (executado).
12,5m a executar.

SISTEMA DE ESGOTAMENTO SANITÁRIO
56,41m de extensão de esgoto Ø200mm, com intervenção em APP, localizado na faixa de servidão do Hortência
A executar ainda temos uma substituição de 36m da rede anterior para Ø 300mm.
Em discussão com SABESP.

SISTEMA DE ESGOTAMENTO SANITÁRIO
350m de extensão de esgoto executada (captação das casas vizinhas).
141m de extensão captação das casas vizinhas

SISTEMA DE ABASTECIMENTO DE GÁS
Gás natural.

TERRENO

DRENAGEM
Considerado canalização de vala aberta para drenagem externa (executada)
Extensão de drenagem com rede em tubo de 600mm e recomposição de via.

Operações

Matriz Risco Concessionária	
Água	Nível 3
Esgoto	Nível 3
Drenagem	Nível 2
Elétrica	NA
Gás	NA
Urbanização	NA

LEGENDA		
Nível	Tipo	Status
1	Com Diretriz	Conclusiva
2		Conclusiva com projeto aprovado
3		Conclusiva sem projeto aprovado
4		Não Conclusiva
5	Sem Diretriz	-
NA	-	Não aplicável

Água:
- Projeto SABESP ainda não aprovado devido a pendências financeiras em aberto. Projeto possui traçado igual a aprovação anterior, no entanto, ainda não temos a aprovação desse cenário.

Esgoto:
- Projeto SABESP ainda não aprovado devido a pendências financeiras em aberto. Projeto possui traçado igual a aprovação anterior, no entanto, ainda não temos a aprovação desse cenário.

Drenagem:
- Drenagem externa SIURB em 07/2020. Trecho interno já executado.

Elétrica:
- No pedido de ligação definitiva a concessionária pode vir a cobrar reformas necessárias, caso a infraestrutura existente não seja suficiente.

Gás:
Já temos viabilidade. Gás natural.

Urbanização:
- Considerado calçada na testada do empreendimento.

Logística

VIVÊNCIA - CONTAINERS							
DESCRIÇÃO	QUANTIDADE	TAMANHO MÓDULOS	MOBILIZAÇÃO	DESMOBILIZAÇÃO	PRÉ FORMA	ESTRUTURA	ACAB.
CONTAINER PORTARIA (LOG)	CONSIDERAR 1 MÓDULO COM SANITÁRIO E CATRACA	2,41 X 6,92 m	1 MOBILIZAÇÃO	1 DESMOBILIZAÇÃO	TODO PERÍODO	TODO PERÍODO	TODO PERÍODO
CONTAINER PROVISÓRIO (LOG)	CONSIDERAR 8 MÓDULOS DE CONTAINER	2,41 X 6,10 m	1 MOBILIZAÇÃO	1 DESMOBILIZAÇÃO	MEIO PERÍODO	-	-
CONTAINER VIVÊNCIA VERTICALIZADA (LOG)	CONSIDERAR 17 MÓDULOS DE CONTAINERS E 1 ESCADA PARA ACESSO (SENDO 6 NO PAV T. , 6 NO PAV 1 E 5 NO ULTIMO PAV.)	2,41 X 6,10 m	1 MOBILIZAÇÃO	1 DESMOBILIZAÇÃO	MEIO PERÍODO	TODO PERÍODO	TODO PERÍODO

TENDAS_PERÍODOS						
DESCRIÇÃO	QUANTIDADE	LARGURA	COMPRIMENTO	PRÉ FORMA	ESTRUTURA	ACABAMENTO
TENDA ARMADOR (LOG)	1	4,00	4,00	-	TODO PERÍODO	-
TENDA ARMADOR (LOG)	1	4,00	7,00	TODO PERÍODO	-	-
TENDA LAZER (LOG)	1	4,00	4,00	-	TODO PERÍODO	TODO PERÍODO
TENDA MOLDADOR (LOG)	1	2,50	4,00	TODO PERÍODO	TODO PERÍODO	-

LOG_EQUIPAMENTOS E MAQUINÁRIOS						
EQUIPAMENTO	QUANTIDADE	MOBILIZAÇÃO	DESMOBILIZAÇÃO	PRÉ FORMA	ESTRUTURA	ACABAMENTO
BETONEIRA (LOG)	VARIÁVEL	-	-	TODO PERÍODO	TODO PERÍODO	-
BOBCAT (LOG)	1 EQUIPAMENTO	1 MOBILIZAÇÃO	1 DESMOBILIZAÇÃO	-	TODO PERÍODO	CONSIDERAR 15 DIAS DO PERÍODO DE ACABAMENTO
BOMBA ESTACIONÁRIA PADRÃO (LOG) R01	1 EQUIP PARA O BLOCO X	-	-	-	TODO PERÍODO	-
CREMALHEIRA CDW (LOG)	2 EQUIPAMENTOS	1 MOBILIZAÇÃO	1 DESMOBILIZAÇÃO	-	TODO PERÍODO	TODO PERÍODO
MINIGRUA (LOG)	2 EQUIPAMENTOS	1 MOB POR MINIGRUA POR TORRE (TAKT 2X2)	1 DESMOB POR MINIGRUA POR TORRE (TAKT 2X2)	-	TODO PERÍODO	-

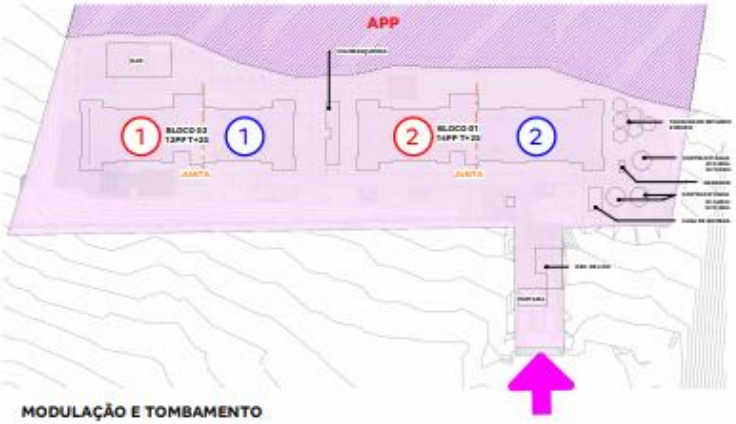

MODULAÇÃO E TOMBAMENTO
1 : 750

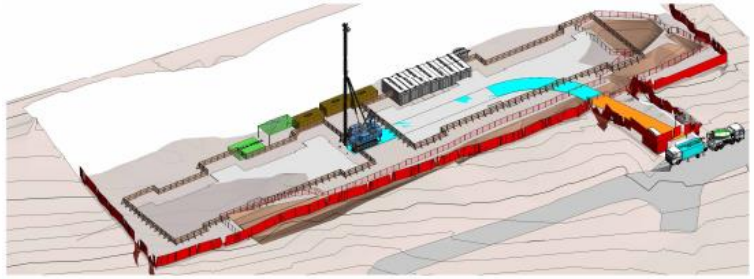

VISTA 3D - PRÉ FORMA

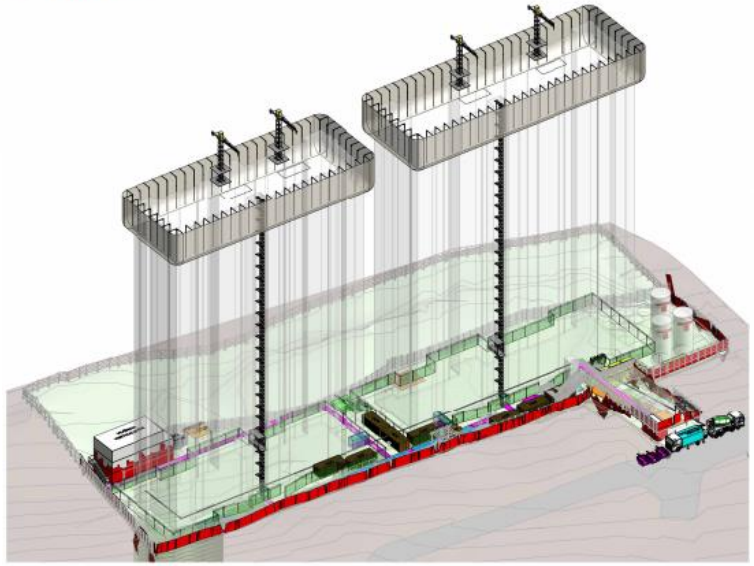

VISTA 3D - ESTRUTURA E ACABAMENTO

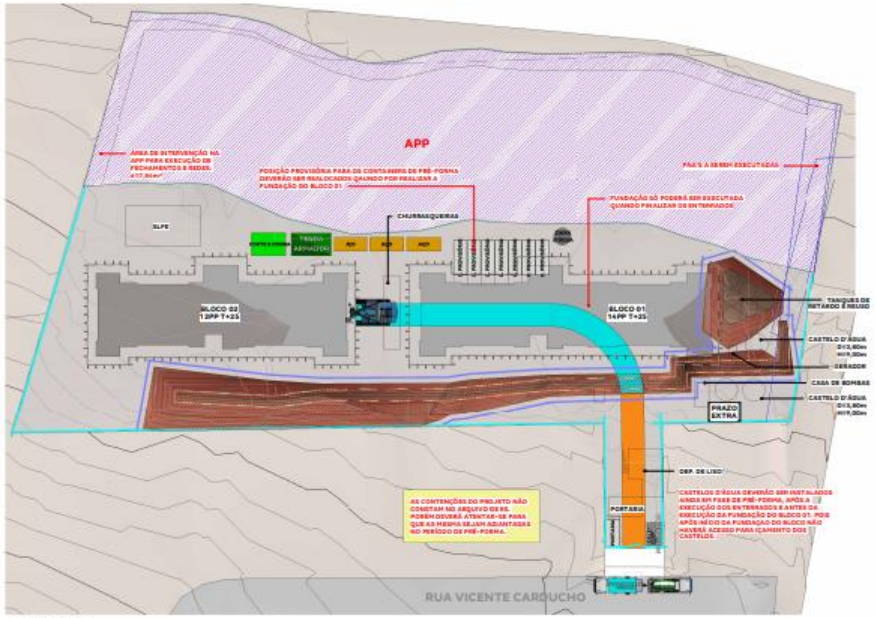

PRÉ FORMA
1 : 500

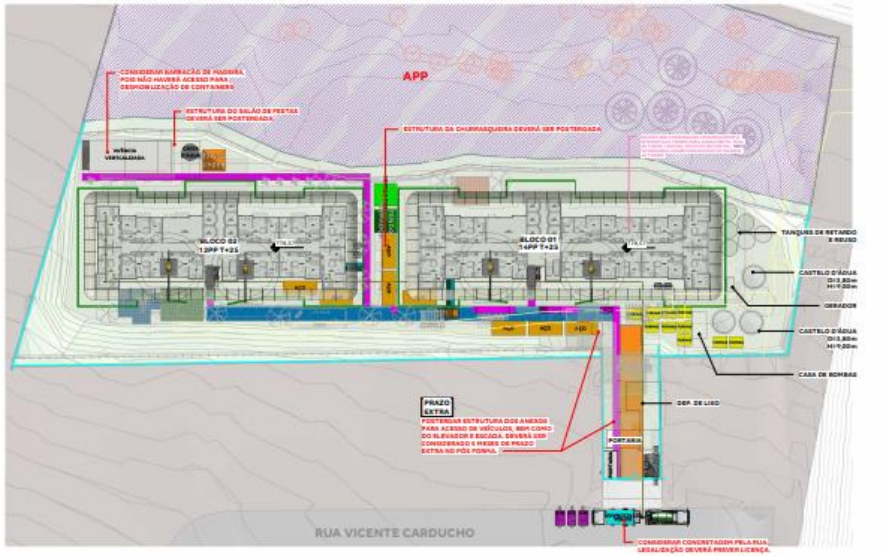

ESTRUTURA E ACABAMENTO
1 : 500

Logística

DÁLIA – SP

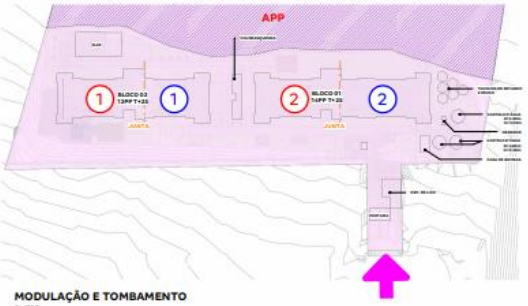

MODULAÇÃO E TOMBAMENTO
1 : 750

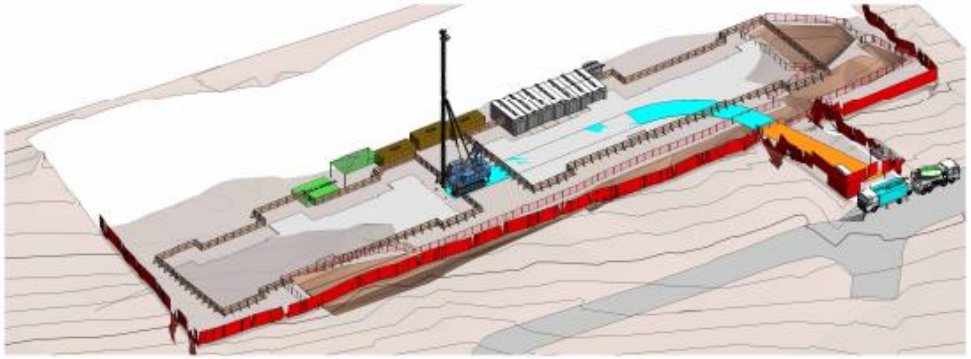

VISTA 3D - PRÉ FORMA

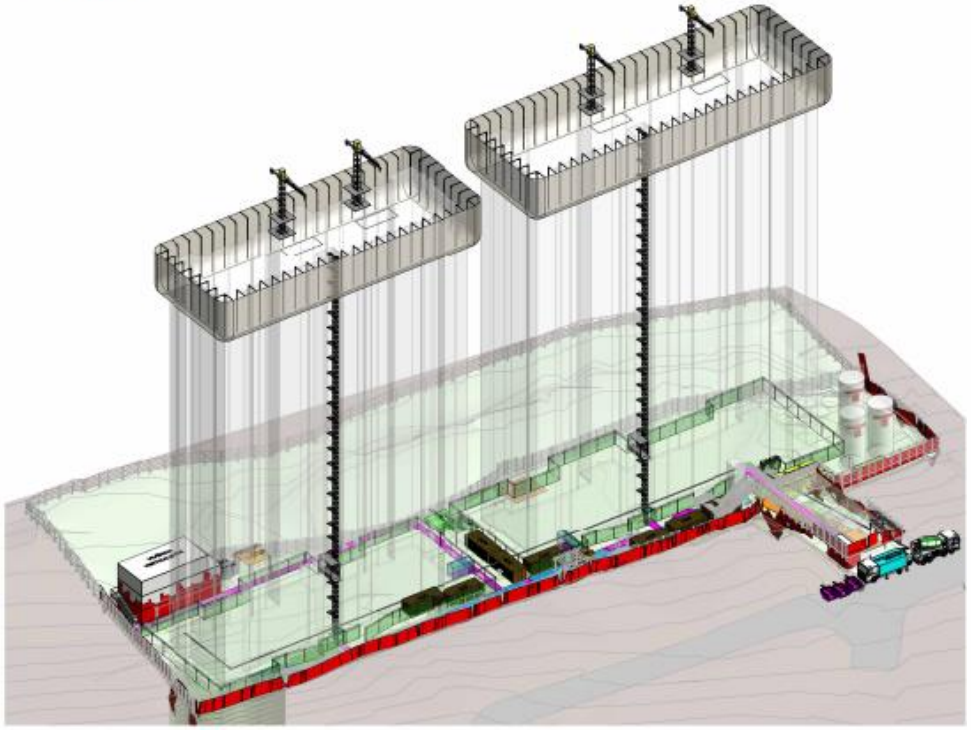

VISTA 3D - ESTRUTURA E ACABAMENTO

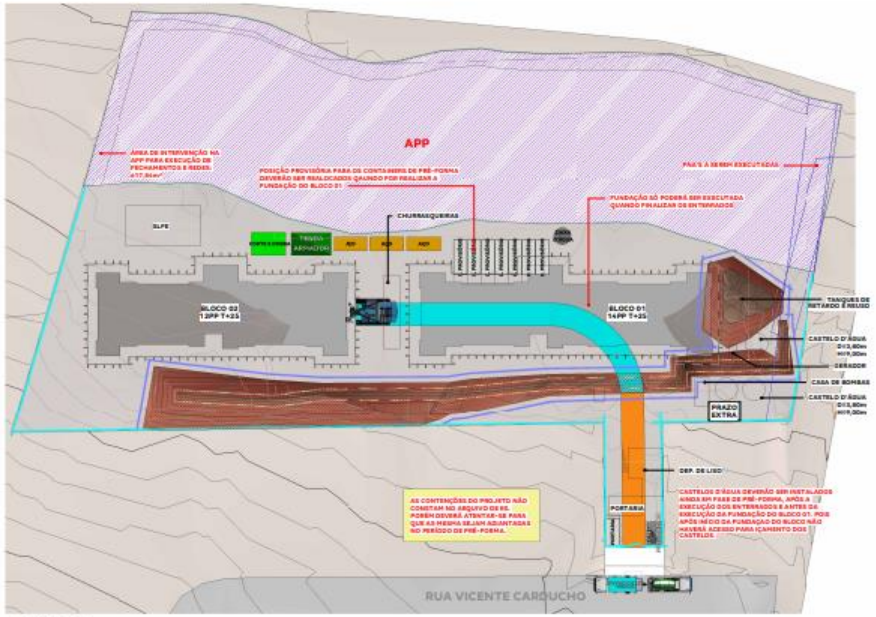

PRÉ FORMA
1 : 500

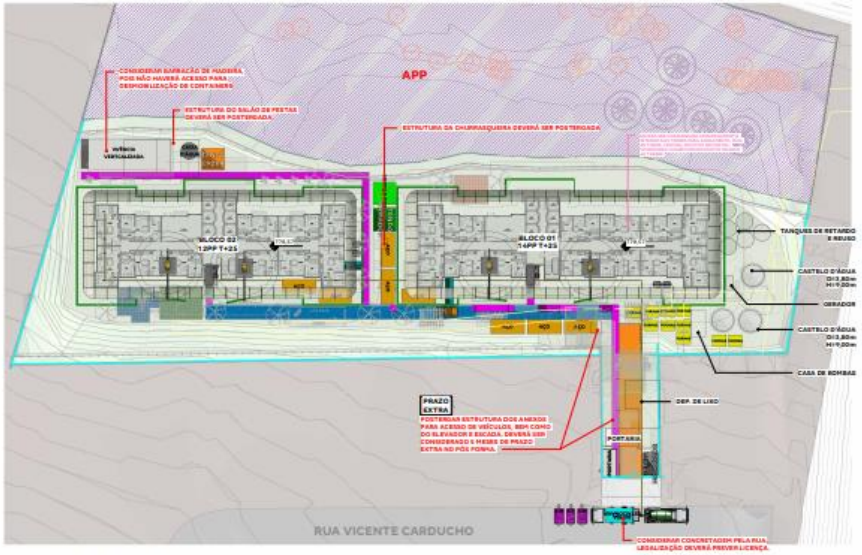

ESTRUTURA E ACABAMENTO
1 : 500

Logística

ITENS A SEREM CONSIDERADOS:

➢ **CUSTOS / OBRA**	PREVER CUSTOS COM LOCAÇÃO DE VIVÊNCIA VERTICALIZADA (T+2), DEVIDO À FALTA DE ESPAÇO NA IMPLANTAÇÃO PARA LOCAÇÃO DA VIVÊNCIA PADRÃO. CONSIDERAR 17 MÓDULOS DE CONTAINERS E 1 ESCADA PARA ACESSO (6 CONTAINERS NO PAVIMENTO TÉRREO, 6 NO P1° PAVIMENTO E 5 NO ULTIMO PAVIMENTO). PREVER CUSTO PARA PERDA DE CONCRETO DURANTE O PERÍODO ESTRUTURA COM UTILIZAÇÃO DE BOMBA ESTACIONÁRIA PARA A CONCRETAGEM, NECESSÁRIO DEVIDO AO GABARITO. É IMPRESCINDIVEL A EXECUÇÃO DE POÇO OU REBAIXO PARA ACOMODAÇÃO DA CREMALHEIRA NOS BLOCOS, UMA VEZ QUE NÃO É POSSÍVEL UTILIZAR RAMPA METÁLICA PARA ACESSO DE MATERIAIS. NÃO HÁ ALCANCE DO RAIO DO MUNCK PARA MOBILIZAR E DESMOBILIZAR A CREMALHEIRA DOS BLOCOS . ASSIM, A MOBILIZAÇÃO DEVERÁ SER FEITA COM A BOBCAT. PREVER LARGURA SUFICIENTE PARA PASSAGEM DESTE MAQUINÁRIO E PREVER COM SUPRIMENTOS CONTRATAÇÃO DE CREMALHEIRA COM CABINE DESMONTÁVEL. CASO A CABINE NÃO SEJA DESMONTÁVEL, SERÁ NECESSÁRIO CONTRATAR UM GUINDASTE DE GRANDE PORTE. PREVER PRAZO NO PERÍODO DE PRÉ FORMA PARA EXECUÇÃO DE CONTENÇÕES CRÍTICAS (CONFORME INDICADO EM PROJETO).
	PREVER ARMAZENAMENTO DAS PLACAS DE DRYWALL DENTRO DOS APARTAMENTOS DO TÉRREO. SERÃO CONSIDERADOS 3 APARTAMENTOS.
➢ **SSO / OBRA**	DEVIDO À FALTA DE ESPAÇO OPERACIONAL, O ARMAZENAMENTO DE FORMAS, AÇO E BAGS FOI CONSIDERADO DENTRO DO ISOLAMENTO PERIFÉRICO. NECESSÁRIO PREVER COBERTURA REFORÇADA, E SSO DEVERÁ FAZER O CONTROLE DE ACESSO. PARA TIPOLOGIAS F02E E F2EP, INCLUIR UM EXTINTOR A. B. C. (6KG) EM CADA INTERVALO DE CINCO PAVIMENTOS DA TORRE, NÃO ULTRAPASSANDO A DISTÂNCIA MÁXIMA DE 15M NO PLANO VERTICAL.
➢ **LEGALIZAÇÃO**	PREVISTO FAIXA DE TRABALHO DE 3,00m, CONFORME INDICADO NO PARECER, PARA EXECUÇÃO DO FECHAMENTO DO CONDOMÍNIO NA APP, FECHAMENTO DA ÁREA DE DOAÇÃO E FECHAMENTO DA ÁREA INSTITUCIONAL. LEGALIZAÇÃO DEVERÁ PREVER O LICENCIAMENTO. FNA DE REDE DE ESGOTO EXISTENTE COM SEU CAMINHAMENTO DENTRO DO LIMITE DO TERRENO, LOTE VIZINHO E ÁREA DE APP. ***SE FOR NECESSÁRIO MANUTENÇÃO, CONSULTAR LEGALIZAÇÃO PARA LICENCIAMENTO DE FAIXA DE TRABALHO.
	PREVER LICENÇA PARA UTILIZAÇÃO DO VIÁRIO PÚBLICO DURANTE AS CONCRETAGENS .

SP - Modular 3.0

1 JOGO = 47 Aptos/mês

Empreendimento	Lançto.	Unidades	# jogos	Equipes de forma	Início Obra	Início Forma 1	Início Forma 2	Início Forma 3	Término Forma 1	Término Forma 2	Término Forma 3	Previsão AGI
CDW 10 | Oásis Penha	jul/25	672	2	B	22/01/26	06/07/26	06/07/26		08/02/27	08/02/27		nov/27
CDW 15 | Jd dos Prados	ago/25	800	2	D	11/02/26	26/06/26	01/07/26		12/03/27	17/03/27		dez/27
CDW 15 | Sobral	set/25	577	2	F	05/01/26	03/08/26	16/08/26		06/02/27	19/02/27		nov/27
CDW 10 | Adriático	out/25	646	2	F	18/07/26	07/02/27	20/02/27		04/09/27	17/09/27		jun/28
CDW 15 | Dália	out/25	667	2	B	23/06/26	09/02/27	09/02/27		13/09/27	13/09/27		out/28
CDW 15 | Horizonte Jaraguá	dez/25	514	2	D	03/03/26	13/03/27	18/03/27		27/08/27	01/09/27		mai/28
CDW 15 | Vila Butantã	fev/26	793	2	A	02/07/26	27/05/27	29/05/27		08/02/28	10/02/28		out/28

Pareceres

Análise da Mancha e Implantação

Operações

Inteligência de Mercado

Financeiro

Demanda e Distribuição da Mancha

Potencial de Demanda			Lançados		Lançados + Landbank	
Mancha	CÓD.	Shr.	ANO	MÊS	ANO	MÊS
São Paulo Sul	SZS	21%	1.459	122	1.750	146

Empreendimento	Renda	Lançamento	set/25	out/25	nov/25	dez/25	jan/26	fev/26	mar/26	abr/26	mai/26	jun/26	jul/26	ago/26	set/26	out/26	nov/26	dez/26	jan/27	fev/27	mar/27	abr/27	mai/27	jun/27
Vista Vila Das Belezas	3.800	nov-24	29	29	29	29	29	29	29	18														
Dália	**3.399**	**set-25**		**37**	**37**	**37**	**37**	**37**	**37**	**37**	**37**	**37**	**37**	**37**	**37**	**37**	**37**	**37**	**37**	**37**	**37**	**1**		
Essência Do Campo Fase 1	3.584	fev-26							31	31	31	31	31	31	31	31	31	31	31	31	31	31	31	31
Total de Vendas Lançados			**29**	**29**	**29**	**29**	**29**	**29**	**29**	**18**	**0**	**0**	**0**	**0**	**0**	**0**	**0**	**0**	**0**	**0**	**0**	**0**	**0**	**0**
Total de Vendas Lançados + Landbank			**29**	**66**	**66**	**66**	**66**	**66**	**97**	**86**	**68**	**68**	**68**	**68**	**68**	**68**	**68**	**68**	**68**	**68**	**68**	**32**	**31**	**31**

Parecer de I.M sobre a mancha:

O projeto analisado em comitê está em linha com o potencial teórico de demanda calculado para a mancha. (Total Lançados)

Canibalização:

Sem Risco de Canibalização

Dália | Mapa Concorrência

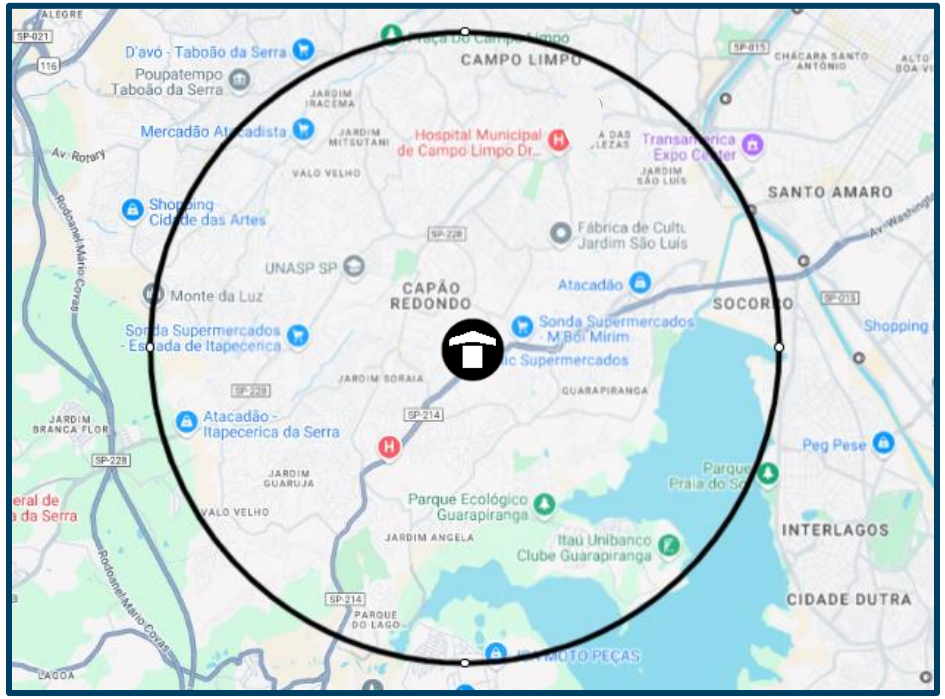

Diagnóstico Concorrência

- Não identificamos concorrência mapeada na região. Abaixo, apresentamos os dados sociodemográficos do entorno do projeto Dália, em comparação com o Vista Vila das Belezas, que é a referência para a regional.

Região 1 Km	Empreendimento	Dália	Vista Vila Das Belezas
	População	62.487	50.097
	Dens. Demográfica	20.019	16.022
	Renda (R$)	4.395	5.755
	Classe Social	C1 (2.7k a 4.6k)	C1 (2.7k a 4.6k)
	PEA Dia	25.274	34.288

Simulação de Preço

Informações Viabilidade

Projeto:	Dália					
Tipo:	**HIS**		**HMP**		**HMP - VARANDA**	
Método	**Vision**		**Vision**		**Vision**	
Avaliação	270.000		270.000		293.000	
Renda Inicial (VF)	3.258		3.499		3.699	
Renda Final*	-		-		-	
% RET1	25%		25%		25%	
Tipo:	**VF**	**R$**	**VF**	**R$**	**VF**	**R$**
Ato	0,48	1.575	0,82	2.895	1,05	3.918
FGTS	0,89	2.926	0,91	3.240	0,90	3.371
Financiamento	96,14%	174.429	95,31%	183.016	95,45%	189.294
Subsídio	115,09%	5.702	135,28%	4.010	155,10%	3.595
Prazo de Pró-soluto	36	36	36	36	36	36
Pró-Soluto	86,82%	36.997	85,62%	39.184	82,04%	39.694
Preço Raso (RS)	221.630	221.630	232.345	232.345	239.873	239.873
TCD	42,19%	13.855	45,69%	16.116	56,08%	20.911
VSO	22	22	7	7	8	8
Preço de Venda	**232.577**	**232.577**	**245.393**	**245.393**	**257.564**	**257.564**
Elasticidade	1,250%	1,250%	1,250%	1,250%	1,250%	1,250%
Preço de Venda Final	**235.485**	**235.485**	**248.461**	**248.461**	**260.784**	**260.784**
Preço Raso (R$)	**221.630**		**232.345**		**239.873**	
% de Raso	**94,12%**		**93,51%**		**91,98%**	
BP25 - Não Inflacionado	**209.042**		**220.869**		**-**	
BP25 - Inflacionado	**217.305**		**229.608**		**-**	

Análise de Preço

Informações Viabilidade

Projeto:	Dália
Tipo:	**Faixa 2**
Método	**Vision**
Avaliação	275.172
Renda Inicial (VF)	3.399
Renda Final*	-

Tipo:	VF	R$
Ato	0,66	2.332
FGTS	0,89	3.081
Financiamento	95,84%	179.265
Subsídio	127,60%	4.934
Prazo de Pró-soluto	36	36
Pró-Soluto	85,53%	37.984
Preço Raso (RS)	227.596	227.596
TCD	45,92%	15.835
VSO	37	37
Preço de Venda	**240.388**	**240.388**
Elasticidade	1,250%	1,250%
Preço de Venda Final	**243.431**	**243.431**
Preço Raso (R$)	**227.596**	
% de Raso	**93,50%**	
Raso Todas as Fases	**227.596**	
Nominal Todas as Fases	**243.431**	

1

Análise de Riscos	Farol IM
IM avalia o Preço Vision como **factível**.	

1) I.M está de acordo com o preço do Vision, considerando que o projeto Vista Vila das Belezas já performou com a renda estimada no parecer. O Dália apresenta um preço inferior por estar localizado em uma área menos favorecida em comparação ao Vista Vila das Belezas.

Conforme consta no slide "Panorama de Concorrência", não mapeamos concorrência na região.

Abaixo segue o escalonamento da regional:

	Preço Real					Preço Normalizado (36m)	
	Avaliação	Preço Raso	Renda Média	VSO	PSOL	Δ PSOL	Preço Raso
Vista Vila das Belezas	**259.500**	**230.577**	**3.800**	**30**	**25**	**13.827**	**244.404**
Dália	**275.172**	**227.596**	**3.399**	**37**	**36**	**-**	**227.596**

Informações Viabilidade

Projeto:	Dália					
Tipo:	**HIS**		**HMP**		**HMP - VARANDA**	
Método	**Vision**		**Vision**		**Vision**	
Avaliação	270.000		270.000		293.000	
Renda Inicial (VF)	3.258		3.499		3.699	
Renda Final*	-		-		-	
% RET1	25%		25%		25%	
Tipo:	**VF**	**R$**	**VF**	**R$**	**VF**	**R$**
Ato	0,48	1.575	0,82	2.895	1,05	3.918
FGTS	0,89	2.926	0,91	3.240	0,90	3.371
Financiamento	96,14%	174.429	95,40%	183.016	95,56%	189.294
Subsídio	115,09%	5.702	135,28%	4.010	155,10%	3.595
Prazo de Pró-soluto	33	33	33	33	33	33
Pró-Soluto	86,82%	33.914	85,62%	35.918	82,04%	36.386
Preço Raso (RS)	218.547	218.547	229.079	229.079	236.565	236.565
TCD	51,58%	16.939	45,69%	16.116	56,08%	20.911
VSO	22	22	7	7	8	8
Preço de Venda	**232.578**	**232.578**	**242.168**	**242.168**	**254.297**	**254.297**
Elasticidade	1,250%	1,250%	1,250%	1,250%	1,250%	1,250%
Preço de Venda Final	**235.485**	**235.485**	**245.195**	**245.195**	**257.476**	**257.476**
Preço Raso (R$)	**218.547**		**229.079**		**236.565**	
% de Raso	**92,81%**		**93,43%**		**91,88%**	
BP25 - Não Inflacionado	**206.772**		**218.599**		**-**	
BP25 - Inflacionado	**215.035**		**227.338**		**-**	

Ciclo Financeiro – Análise Mancha

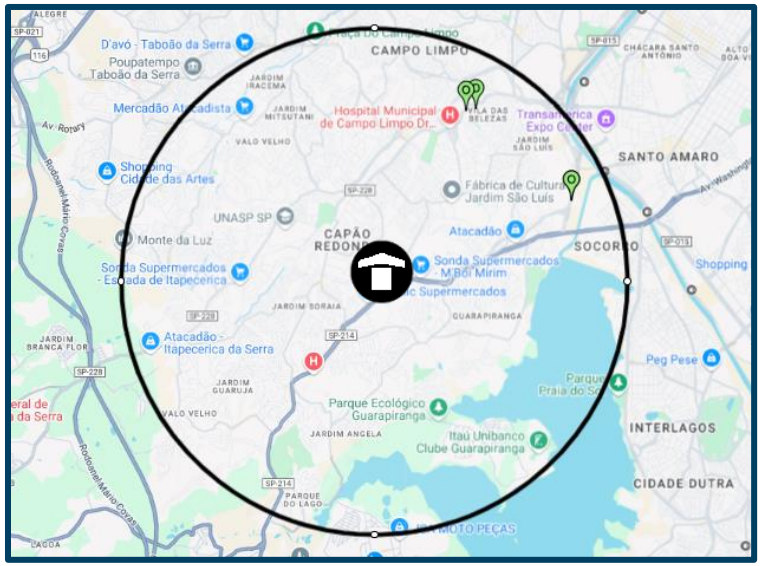

Parecer Ciclo

O Ciclo avaliou o preço e o VSO como factíveis. O projeto está localizado em uma região estratégica na zona Sul e com grande potencial de demanda, sem concorrentes diretos.

Entendemos que há grande potencial de ganho entre volume de vendas e preço.

Pareceres

Análise da Mancha e Implantação

Operações

Inteligência de Mercado

Financeiro

Informações Gerais – Consolidado

Dália – SP – São Paulo Capital

Datas e Prazos

	Compra	Lançamento	Início Obra	Término Obra	LÇTO até IO	IO até TO	Chaves	LÇTO até Chaves
Consolidado	set-18							
Dalia- HIS 1		set-25	mar-26	jul-28	6 meses	28 meses	set-28	36 meses
Dalia- HIS 2- HMP		set-25	mar-26	jul-28	6 meses	28 meses	set-28	36 meses
Dalia- HIS2-HMP- VARANDA		set-25	mar-26	jul-28	6 meses	28 meses	set-28	36 meses

Terreno e Incorridos

TOTAL (R$ + Perm.):	12,13 MM	Incorrido Terreno:	0,00 MM	Área do Terreno (100%):	9.071 m²
Cash:	0,00 MM	Nº de Parcelas Cash :	0	Custo de terreno m²:	1.336,9
Permuta Financeira:	12,13 MM (7,51%)			VaR 25 (R$ mil):	0
Permuta Física:	0,00 MM (0,00%)			VaR 26 (R$ mil):	0
Ato / %VGV:	0,00 MM / 0,0%			Incorrido de Construção:	0,00 MM

Área Líquida do Terreno:	5.157 m²
Custo de terreno m² Área Líquida:	2.351,5
Fração Terreno/Terreno + Custo Obra (%VGV):	7,5% / 52,5%
CA Máx/Proj.	4,4 / 2,4
Incorridos de Incorporação:	0,00 MM

Vendas

Fases	Nº Pavimentos	Preço Raso Unit.	Qtde	Preço Unit.	Aval. CEF	Cond. Parcela	% Pró-soluto	% TCD
Dalia- HIS 1	T+25	218.547	401	235.485	270.000	96,1%	86,8%	51,6%
Dalia- HIS 2- HMP	T+25	229.079	116	245.195	270.000	95,4%	85,6%	45,7%
Dalia- HIS2-HMP- VARANDA	T+25	236.565	150	257.476	293.000	95,6%	82,0%	56,1%

Unidades Totais:	667	Preço Médio:	242.119	Renda Média:	3.399	ITBI+Emol. Unit. Médio:	4.617
Unidades Tenda:	667	Avaliação Média:	275.172	Ato:	2.259 (0,66 Salários)	Custo do Ciclo Unit.:	15.241
VSO:	37 Unidades	VGV Total:	161.493.657	FGTS:	3.042 (0,89 Salários)	Preço Raso Médio:	224.430
RET Médio:	3,3%	VGV Tenda:	161.493.657	% em RET 1%:	25%	Adc. Tx. de Aceleração Médio:	750

Construção

Custo Total Unit.:	108.871	Eventuais:	4,00%	Área priv (m²):	32,00	Gape / Mês Unit.:	11,08

Resultado

LI (R$):	22.641.151	LI:	20,29%	Exposição de Caixa (R$):	10.638.122	Margem Bruta Econômica:	37,35%
TIR:	161,73%	LI Aprovação:	20,00%	Ger. Caixa 12 meses (R$):	(9.515.369)	Margem Bruta REF:	40,77%
Exposição de Caixa:	6,64%	Δ LI:	0,29%	Ger. Caixa 24 meses (R$):	13.335.412	Margem Rasa Econômica:	31,63%
Payback Contingente (21 m):	20 m/ (-1 m)	LI Marginal:	20,33%	Ger. Caixa Marginal (R$):	38.542.800	Margem Rasa REF:	36,11%
Payback Consolidado:	20 meses					Margem de Contribuição Econômica:	25,94%

DRE (Consolidado)

R$ Mil - Valores Nominais - Compra	Dália		Dalia- HIS 1		Dalia- HIS 2- HMP		Dalia- HIS2-HMP- VARANDA	
	Nominal	%	Nominal	%	Nominal	%	Nominal	%
Receita	160.244	100,0%	93.660	100,0%	28.236	100,0%	38.347	100,0%
PIS/COFINS	(2.856)	1,8%	(1.669)	1,8%	(503)	1,8%	(683)	1,8%
Custo Total	(98.600)	62,6%	(59.064)	64,2%	(17.151)	61,8%	(22.384)	59,4%
Custo Terreno	(12.033)	7,6%	(7.033)	7,6%	(2.120)	7,6%	(2.879)	7,6%
Custo Relacionados a Terreno	(805)	0,5%	(476)	0,5%	(141)	0,5%	(188)	0,5%
Custos de Incorporação	(2.544)	1,6%	(1.524)	1,7%	(417)	1,5%	(602)	1,6%
Custo de Construção	(83.218)	52,9%	(50.030)	54,4%	(14.473)	52,2%	(18.715)	49,7%
Lucro Bruto Econômico	58.788	37,4%	32.927	35,8%	10.582	38,2%	15.279	40,6%
Custo para Rateio	-	0,0%	-	0,0%	-	0,0%	-	0,0%
Lucro Bruto Contábil	58.788	37,4%	32.927	35,8%	10.582	38,2%	15.279	40,6%
Despesas de Selling	(14.272)	9,1%	(7.659)	8,3%	(2.804)	10,1%	(3.808)	10,1%
Contingência	(3.686)	2,3%	(2.154)	2,3%	(649)	2,3%	(882)	2,3%
Margem de Contribuição	40.831	25,9%	23.114	25,1%	7.128	25,7%	10.589	28,1%
IR e CSLL	(2.337)	1,5%	(1.366)	1,5%	(412)	1,5%	(559)	1,5%
Margem Líquida	38.494	24,5%	21.748	23,6%	6.716	24,2%	10.030	26,6%
Lucro Bruto REF Unit.	100.726	40,8%	94.524	39,3%	103.321	41,4%	115.301	43,9%
Lucro Raso REF Unit.	82.692	36,1%	77.253	34,6%	86.916	37,2%	93.963	38,9%

R$ Mil - VPL - Compra	Dália		Dalia- HIS 1		Dalia- HIS 2- HMP		Dalia- HIS2-HMP- VARANDA	
	VP	%	VP	%	VP	%	VP	%
Receitas	111.587	100,0%	65.223	100,0%	19.827	100,0%	26.537	100,0%
PIS/COFINS	(1.959)	1,8%	(1.145)	1,8%	(348)	1,8%	(466)	1,8%
Custos e Despesas Totais	(86.987)	78,0%	(51.311)	78,7%	(15.443)	77,9%	(20.233)	76,2%
Custo Terreno	(8.021)	7,2%	(4.688)	7,2%	(1.425)	7,2%	(1.907)	7,2%
Custo Relacionados a Terreno	(777)	0,7%	(460)	0,7%	(136)	0,7%	(181)	0,7%
Custos de Incorporação	(1.898)	1,7%	(1.135)	1,7%	(309)	1,6%	(454)	1,7%
Custo de Construção	(61.025)	54,7%	(36.688)	56,2%	(10.613)	53,5%	(13.724)	51,7%
Despesas de Selling	(12.396)	11,1%	(6.663)	10,2%	(2.451)	12,4%	(3.282)	12,4%
Contingência	(1.267)	1,1%	(741)	1,1%	(223)	1,1%	(303)	1,1%
IR e CSLL	(1.603)	1,4%	(937)	1,4%	(285)	1,4%	(381)	1,4%
Lucro Imobiliário	22.641	20,3%	12.768	19,6%	4.036	20,4%	5.837	22,0%

Informações Gerais – Consolidado

Dalia - SP - São Paulo Capital

Datas e Prazos

	Compra	Lançamento	Início Obra	Término Obra	LÇTO até IO	IO até TO	Chaves	LÇTO até Chaves
Consolidado	set-18							
Dalia- HIS 1		set-25	jun-26	out-28	9 meses	28 meses	set-28	36 meses
Dalia- HIS 2- HMP		set-25	jun-26	out-28	9 meses	28 meses	set-28	36 meses
Dalia- HIS2-HMP- VARANDA		set-25	jun-26	out-28	9 meses	28 meses	set-28	36 meses

Terreno e Incorridos

TOTAL (R$ + Perm.):	6,97 MM	Incorrido Terreno:	5,99 MM	Área do Terreno (100%):	9.071 m²	Área Líquida do Terreno:	5.157 m²
Cash:	5,99 MM	Nº de Parcelas Cash :	30	Custo de terreno m²:	768,0	Custo de terreno m² Área Líquida:	1.350,9
Permuta Financeira:	0,00 MM (0,00%)			VaR 25 (R$ mil):	0	Fração Terreno/Terreno + Custo Obra (%VGV):	4,3% / 49,8%
Permuta Física:	0,98 MM (0,60%) - Unidades Permuta 4,00			VaR 26 (R$ mil):	0	CA Máx/Proj.	4,4 / 2,4
Ato / %VGV:	0,05 MM / 0,0%			Incorrido de Construção:	1,81 MM	Incorridos de Incorporação:	3,16 MM

Vendas

Fases	Nº Pavimentos	Preço Raso Unit.	Qtde	Preço Unit.	Aval. CEF	Cond. Parcela	% Pró-soluto	% TCD
Dalia- HIS 1	T+25	221.630	401	235.485	270.000	96,1%	86,8%	42,2%
Dalia- HIS 2- HMP	T+25	232.345	116	248.461	270.000	95,3%	85,6%	45,7%
Dalia- HIS2-HMP- VARANDA	T+25	239.873	150	260.784	293.000	95,4%	82,0%	56,1%

Unidades Totais:	667	Preço Médio:	243.431	Renda Média:	3.399	ITBI+Emol. Unit. Médio:	4.678
Unidades Tenda:	663	Avaliação Média:	275.172	Ato:	2.259 (0,66 Salários)	Custo do Ciclo Unit.:	15.324
VSO:	37 Unidades	VGV Total:	162.368.288	FGTS:	3.042 (0,89 Salários)	Preço Raso Médio:	227.596
RET Médio:	3,3%	VGV Tenda:	161.394.565	% em RET 1%:	25%	Adc. Tx. de Aceleração Médio:	750

Construção

Custo Total Unit.:	110.794	Eventuais:	4,00%	Área priv (m²):	32,00	Gape / Mês Unit.:	11,08

Resultado

LI (R$):	5.727.656	LI:	5,26%	Exposição de Caixa (R$):	19.377.889	Margem Bruta Econômica:	37,97%
TIR:	22,36%	LI Aprovação:	20,00%	Ger. Caixa 12 meses (R$):	(7.743.157)	Margem Bruta REF:	41,31%
Exposição de Caixa:	12,01%	Δ LI:	-14,74%	Ger. Caixa 24 meses (R$):	12.048.176	Margem Rasa Econômica:	32,96%
Payback Contingente (21 m):	23 m/ (2 m)	LI Marginal:	27,89%	Ger. Caixa Marginal (R$):	50.831.901	Margem Rasa REF:	37,23%
Payback Consolidado:	23 meses					Margem de Contribuição Econômica:	26,62%

DRE (Consolidado)

R$ Mil - Valores Nominais - Compra	Dalia		Dalia- HIS 1		Dalia- HIS 2- HMP		Dalia- HIS2-HMP- VARANDA	
	Nominal	%	Nominal	%	Nominal	%	Nominal	%
Receita	161.400	100,0%	93.728	100,0%	28.707	100,0%	38.964	100,0%
PIS/COFINS	(2.857)	1,8%	(1.661)	1,8%	(507)	1,8%	(689)	1,8%
Custo Total	(98.339)	62,0%	(58.983)	64,1%	(17.164)	60,9%	(22.191)	58,0%
Custo Terreno	(7.089)	4,5%	(4.128)	4,5%	(1.320)	4,7%	(1.641)	4,3%
Custo Relacionados a Terreno	(2.256)	1,4%	(1.356)	1,5%	(392)	1,4%	(507)	1,3%
Custos de Incorporação	(3.578)	2,3%	(2.147)	2,3%	(597)	2,1%	(834)	2,2%
Custo de Construção	(85.415)	53,9%	(51.352)	55,8%	(14.855)	52,7%	(19.209)	50,2%
Lucro Bruto Econômico	60.204	38,0%	33.084	35,9%	11.036	39,1%	16.084	42,0%
Custo para Rateio	-	0,0%	-	0,0%	-	0,0%	-	0,0%
Lucro Bruto Contábil	60.204	38,0%	33.084	35,9%	11.036	39,1%	16.084	42,0%
Despesas de Selling	(14.281)	9,0%	(7.620)	8,3%	(2.816)	10,0%	(3.845)	10,0%
Contingência	(3.712)	2,3%	(2.156)	2,3%	(660)	2,3%	(896)	2,3%
Margem de Contribuição	42.211	26,6%	23.308	25,3%	7.560	26,8%	11.343	29,6%
IR e CSLL	(2.337)	1,4%	(1.359)	1,4%	(415)	1,4%	(564)	1,4%
Margem Líquida	39.874	25,2%	21.949	23,8%	7.146	25,3%	10.779	28,2%
Lucro Bruto REF Unit.	102.602	41,3%	94.879	39,5%	106.668	42,1%	120.101	45,1%
Lucro Raso REF Unit.	86.462	37,2%	80.760	35,7%	90.266	38,1%	98.766	40,3%

R$ Mil - VPL - Compra	Dalia		Dalia- HIS 1		Dalia- HIS 2- HMP		Dalia- HIS2-HMP- VARANDA	
	VP	%	VP	%	VP	%	VP	%
Receitas	108.820	100,0%	63.375	100,0%	19.428	100,0%	26.017	100,0%
PIS/COFINS	(1.897)	1,7%	(1.106)	1,7%	(338)	1,7%	(453)	1,7%
Custos e Despesas Totais	(101.195)	93,0%	(59.862)	94,5%	(17.954)	92,4%	(23.379)	89,9%
Custo Terreno	(15.085)	13,9%	(8.981)	14,2%	(2.682)	13,8%	(3.421)	13,1%
Custo Relacionados a Terreno	(4.033)	3,7%	(2.425)	3,8%	(701)	3,6%	(907)	3,5%
Custos de Incorporação	(4.133)	3,8%	(2.479)	3,9%	(698)	3,6%	(955)	3,7%
Custo de Construção	(62.761)	57,7%	(37.732)	59,5%	(10.915)	56,2%	(14.114)	54,3%
Despesas de Selling	(12.409)	11,4%	(6.630)	10,5%	(2.463)	12,7%	(3.316)	12,7%
Contingência	(1.222)	1,1%	(710)	1,1%	(217)	1,1%	(295)	1,1%
IR e CSLL	(1.552)	1,4%	(905)	1,4%	(276)	1,4%	(371)	1,4%
Lucro Imobiliário	5.728	5,3%	2.406	3,8%	1.137	5,9%	2.184	8,4%

Comparativo Real

Comparativo dos Estudos - Consolidado	BP - 2025	Atual	Atual vs BP - 2025	Δ%
Data Estudo:	setembro-24	setembro-25	12 Meses	N/A
Lançamento:	outubro-25	setembro-25	-1 Meses	N/A
Uhs:	667	667	-	0,0%
Preço Nominal:	226.243	243.431	17.188	7,6%
Preço Raso:	209.296	227.596	18.300	8,7%
Preço Nominal Inflacionado:	248.195	248.368	173	0,1%
Preço Raso Inflacionado:	229.612	232.228	2.617	1,1%
Renda Média:	2.789	3.399	610	21,9%
RET Médio:	3,25%	3,25%	0,0 p.p.	0,0%
% em RET 1%:	25,00%	25,00%	0,0 p.p.	0,0%
Ato:	1,0	0,7	(0,4)	-35,7%
FGTS:	0,0	0,9	0,9	
VSO:	37	37	-	0,0%
VSO2:	37	37	-	0,0%
ITBI/Emol. Inf (Unit)[2]:	5.829	5.393	(437)	-7,5%
Avaliação:	240.000	275.172	35.172	14,7%
Cond. Financiamento:	117,4%	95,8%	-21,5 p.p.	-18,4%
Subsídio Utilizado:	0,0%	127,6%	127,6 p.p.	
Percentual Pró-Soluto:	74,7%	85,5%	10,8 p.p.	14,5%
Percentual utilização TCD:	60,3%	45,9%	-14,4 p.p.	-23,8%
Prazo construção F1:	25	28	3	12,0%
Prazo de Pró-Soluto F1:	30	36	6	20,0%
Custo Total Inf (Unit):	148.369	147.434	(934)	-0,6%
Custo Construção (Unit):	107.166	110.794	3.628	3,4%
Custo Construção Corrigido:	108.511	110.794	2.283	2,1%
Fração de construção:	48,0%	45,5%	-2,4 p.p.	-5,1%
INCC Folha Rosto:	1.126,92	1.210,47	84	7,4%
Custo Terreno Inf:	7.068.248	7.089.388	21.139	0,3%
Custo Relacionados a Terreno (Unit):	3.562	3.382	(180)	-5,1%
Fração do Terreno[1]:	4,6% / 51,9%	4,3% / 49,8%	-0,3 p.p.	-6,5%
ITBI/Emol. Inf (Total)[2]:	3.888.257	3.597.027	(291.230)	-7,5%
Custo do Ciclo (Unit):	14.242	15.324	1.082	7,6%
Lucro Imobiliário:	5,2%	5,3%	0,0 p.p.	0,3%
Penalty Varandas:	N/A	N/A	N/A	
LI Ajustada:	N/A	N/A	N/A	
LI Marginal:	26,3%	27,9%	1,6 p.p.	5,9%
Exposição de caixa:	15,3%	12,0%	-3,3 p.p.	-21,6%
TIR:	22,5%	22,4%	-0,2 p.p.	-0,7%
Margem Bruta REF:	40,9%	41,3%	0,4 p.p.	1,0%
Margem Bruta Econômica:	37,9%	38,0%	0,0 p.p.	0,1%
Margem Rasa REF:	36,1%	37,2%	1,1 p.p.	3,1%
Margem Rasa Econômica:	32,3%	33,0%	0,7 p.p.	2,1%
Margem Contribuição Econômica:	26,3%	26,6%	0,3 p.p.	1,3%
Payback Contingente (Régua 21 m):	21 m/ (0 m)	23 m/ (2 m)	2	9,5%
Payback Consolidado:	21 Meses	23 Meses	2 Meses	9,5%

[1] Valor do terreno contratual
[2] ITBI com taxa de Aceleração

Obrigado