Tenda

sua próxima conquista

Book de Investimento

Regional: GO

Projeto: Estrada B

Data Comitê: 23/06/2025

Perguntas Comitê Digital 16/06/25 – ESTRADA B

Nome	Estrada B - Investimento	Observação - Estrada B
Andre Luis Menegazzo Padilha	Aprovado	ok
Alexandre Regis de Oliveira	Aprovado	Ok
Renan Barbosa Sanches	Aprovado	ok
Alejandro Octavio Abiusi	Aprovado	ok
Fabricio Quesiti Arrivabene	Aprovado	ok
Luiz Mauricio de Garcia Paula	Aprovado	ok
Amanda da Silva Bezerra	Aprovado	Ok
Rodrigo Osmo	Discutir em Comitê	(1) Impressionante o custo dessa obra. O que explica uma redução tão substancial no custo de instalações de torre (R$1,1K/unidade) na comparação com o videira?

Pergunta Rodrigo Osmo:

1. **(1) Impressionante o custo dessa obra. O que explica uma redução tão substancial no custo de instalações de torre (R$1,1K/unidade) na comparação com o Videira?**

R: Sim, este projeto possui um custo muito competitivo. Comparado ao projeto Videira, ganhamos em número de unidades, o que contribui significativamente para a diluição dos custos indiretos e de infraestrutura. Além disso, o terreno possui uma composição de solo mais resistente, trazendo vantagens na fundação em relação ao Videira.
Quando falamos especificamente de instalações, o estagio de desenvolvimento da nova tipologia, hoje mais avançado quando comparado ao momento da parametrização do Videira, nos habilita a utilizar referencias locais de preço nas quantidades mais detalhadas, que somadas as reduções de preço unitário das última LVS traz essa economia. Ou seja, com as informações que temos hoje, se formos reavaliar o projeto Videira, esperamos estar em linha com esta nova referência ora apresentada no Estrada B.

Destaques

[1]

Cidade	Goiânia	**Mancha de demanda**	GO - GOO - Goiânia Oeste
Regional	GO	**Cluster MPR**	1 - Vermelho
Cenário de Aprovação	Aprovação	**Tipo de Aprovação**	Consolidado
Fase Anterior	N/A		
Tipo de Comitê	Investimento	**Versão da VF**	Versão 1.0: Jun

Unidades (% Vagas)	390 (39%)	**CA Máx | Proj**	2,0 | 1,0
Tipologia	F2 - Concreto	**Escritura**	nov-26
Fases	1 fases	**Lçto | Duração (m)**	jan/27 | 19

[2]

Valor Líquido do Terreno (% VGV)	7.032 (9,0%)	**Un. Perm. Fís (% Ter)**	0 (0,0%)
Cash (Correção)	7.032 (IPCA)	**%VGV Perm Fin Líquida (% Ter)**	0,0% (0,0%)
Valor R$/m²	473	**VAR (%VGV)**	000 (0,0%)

[3]

Custo Construção (%VGV)	31.902 (40,8%)	**Indireto Unit.**	16.393
Prazo da Obra (meses)	13	**Torre Unit.**	37.222
Custo Total Unit. (LPU):	81.800 (LPU 91)	**Infra Unit.**	19.735
Início de Obra	jul-27	**Fundação Unit.**	3.916

Preço Nominal Unit.	200.735	**VSO**	30
Preço Raso Unit.	176.775	**Referência**	Vision
Avaliação Unit.	194.421	**Renda (% em RET 1%)**	2.889 (65,5%)



[4]

LI (Régua):	**22,9% (20,0%)**	**Margem Bruta Econômica:**	43,7%
LI Resiliência:	7,8% (N/A)	**Margem Rasa Econômica:**	35,4%
Margem Bruta REF:	46,0%	**Margem Contribuição Econômica:**	30,3%
Margem Rasa REF:	**38,7%**	**Exposição (% VGV):**	13.248 (15,6%)
TIR:	140,6%	**VGV Total:**	78.286
Payback Contingente (21 m) :	**15 m/ (-6 m)**	**Ger. Caixa 12 meses (R$):**	-
Payback Consolidado:	15	**Ger. Caixa 24 meses (R$):**	(5.489)

[1] Apresentação em Comitê de Investimento do projeto **ESTRADA B**, na Mancha Oeste (Capital). Projeto composto por 1 condomínio de fase única.

O bairro Lorena Park está situado dentro do subdistrito de João Braz, que inclui vários bairros adjacentes (Solange Park, Araguaia Park, entre outros). Trata-se de um bairro consolidado com infraestrutura básica já implantada. A região conta com comércio de bairro, incluindo mercados, padarias, farmácias e serviços. No raio de 1km existe a Escola Municipal Lorena Park e UBS Luana Park. Na Estrada B, via de acesso ao nosso terreno há pontos de ônibus abastecido por 2 linhas.

Este terreno representa um salto de qualificação no que diz respeito a localização frente ao atual landbank da mancha, Estação das Fontes e Lago Azul.

Durante o desenvolvimento do projeto, já está em pauta a implantação de varanda e garden com objetivo de maximizar o VGV.

[2] Negócio em fluxo de cash em 24x com fração de 9%. Garantia do vendedor através do aval Tenda.

[3] Custo de construção consolidado de ~ 81,8 K/UH em tipologia modular.

[4] Indicadores financeiros do projeto consolidado ESTRADA B de MB = 43% e LI = 22,85%.

- Pareceres
- Análise da Mancha e Implantação
- Prospecção
- Operações
- Inteligência de Mercado
- Financeiro

Pareceres – ESTRADA B

Área	Riscos Associados	Parecer	Criticidade
Jurídico	Due diligence em andamento com previsão de conclusão para 30/06. Seguintes pontos de atenção já identificados: i) O contrato foi assinado em 09/05/2025, porém, em 30/05/2025, um dos proprietários faleceu. Será necessário: aditamento contratual a ser assinado pelos herdeiros, prevendo que a Tenda possa realizar o inventário; procuração dos herdeiros conferindo poderes à Tenda para conduzir o inventário.; Resolutivas: O contrato possui cláusula resolutiva master de saída (viabilidade técnica, financeira, comercial e jurídica).	Ok com ressalvas	
Legalização	Sem ressalvas	Ok	
Produto	Ok	Ok	
GETEC	Atualmente não há diretriz de água e esgoto. Conforme indicado pelo projetista, estamos considerando o ponto provável de interligação para entensão de rede de água. Quanto a rede de esgoto, estamos trabalhando com o cenário mais desfavorável, que prevê a implantação de uma ETE. O custo deverá ser revisado após emissão da AVTO.	Ok com ressalvas	
Logística	Ok	Ok	
Contratação	NA	Ok	
Inteligência de mercado	IM avalia Preço Vision como factivel.	Ok	
Comercial/Ciclo	Ciclo avalia Preço como factivel.	Ok	
Estudos Econômicos	Ok, sem riscos	Ok	

Pareceres

Análise da Mancha e Implantação

Prospecção

Operações

Inteligência de Mercado

Financeiro

Mancha de Demanda

MANCHAS DE DEMANDA
Goiânia Oeste + Leste

Lançamento
1. Lago Azul
2. Parque dos Sonhos

LandBank
3. Estação das Fontes III
4. Jardim do Cerrado
5. Recanto das Fontes
6. Frutas
7. Estrada B

Cluster MPR – (Comitê)

Cluster 1 - Vermelho

Região

Capital

Lançados *LandBank* *Comitê*

PRODUTO

Empreendimento GO – ESTRADA B
Investimento

Informações Gerais – Condomínio Único		
Terreno	Área terreno	17.579,39 m²
	Menor poligonal	17.545,62 m²
	Doação	Sim. 2.664,75 m² (15%)
	Reserva de calçada/ melhoramento viário	Não
	Área liquida	14.880,87 m²
	Zoneamento	AAB (fração 45)
	Ca máximo	2,00
	Ca projetado	0,99
	Gabarito máximo	T+4
Geral	Total uh fração x projetado	Fração 390 UH X Projetado 390UH
	Total de vagas	152 (38,97%) sendo 04 PCD
Tipologia	Tipologia	Modular sem elevador
	Gabarito projetado	T+4
	Lâmina	01 18PP, 02 20 PP E 01 20 PP L
	Área privativa	32 m²
Condomínio	Unidade PCD	12
	Unidade lazer | técnica	00
	Torre	04
	Fase	01
Lazer	Lazer coberto	Salão de festas c/ churrasqueira E churrasqueira gourmet
	Lazer descoberto	Playkids, playbaby, playpet, Praça do Ipê do cerrado, Praça de Jogos, Praça do Pequi, Roda de Viola, Pista de Caminhada, Quadra Gramada, piscina e espaço do Tereré

LEGENDA:

01 ÁREA DE LAZER

02 ÁREA TÉCNICA

PRODUTO

Empreendimento GO – ESTRADA B
Investimento

	Descrição	Criticidade	Parecer
Usabilidade	**Limite supercondomínio**		
	Acesso		
	Percurso do pedestre até torre		
Diferencial produto	**Atributos Infra**	Sim	Espaço para mini mercado, piscina e quadra gramada.
	Atributos Torre	Não	-
	Edifício Garagem	Não	-

Perspectiva

Pareceres

Análise da Mancha e Implantação

Prospecção

Operações

Inteligência de Mercado

Financeiro

➢ CONDIÇÕES DO NEGÓCIO

- Trata-se de Compra e Venda que corresponde ao preço de **R$ 7.031.728,00** que será pago em **24 parcelas** mensais de **R$ 292.988,66**. Vencendo-se a primeira na data da outorga da ECV, as demais parcelas terão vencimento no mesmo dia dos meses subsequentes ao vencimento da primeira parcela. As parcelas indicadas serão atualizadas mensalmente, pro rata die, desde a data da assinatura do contrato até o efetivo pagamento, com base na variação acumulada do **IPCA**.

- Negócio em Fluxo de cash conforme parcelas descritas acima, com total equivalente à uma fração líquida de 9% do VGV **(PCV assinada em maio/25).**

- Na PCV o prazo para notificação referente ao atraso no pagamento das parcelas pela Tenda foi negociado para 5 dias.

- Na PCV consta que se o contrato rescindido, esse será mantido com a configuração mais atual que tiver perante o cartório de imóveis e Prefeitura na época da rescisão.

- Não há débitos de IPTU dos imóveis objetos do contrato.

- O imóvel não está ocupado.

➢ OBRIGAÇÕES CONTRATUAIS:

- ECV: o empreendimento deverá ser Escriturado em até **12 meses** a partir da assinatura da PCV, prorrogável automaticamente por mais **6 meses**;

➢ GARANTIAS

- Para os Vendedores:
  - Aval Tenda;

➢ INTERMEDIAÇÃO IMOBILIÁRIA

- Contrato de intermediação assinado em **junho/25.**

- Pagamento será feito após a escritura pública de transferência para a Tenda, em 03 parcelas iguais e fixas. Sendo a primeira em 30, e as demais em 60 e 90 dias.

- A intermediação será no total de 4% do valor fixo e irreajustável do Terreno, sendo **R$ 281.269,12** para **FEND NEGÓCIOS E DESENVOLVIMENTO IMOBILIÁRIO**, inscrita no CRECI PF nº 38059.

- A empresa FEND não possui CRECI Pessoa Jurídica, tendo como condicionante para recebimento da comissão, a efetivação do cadastro como PJ perante o CRECI-GO no prazo de **180 dias** contados a partir da assinatura do contrato de corretagem.

- Pareceres
- Análise da Mancha e Implantação
- Prospecção
- Operações
- Inteligência de Mercado
- Financeiro

Custo de Construção

	ESTRADA B CEN01 | REV00	VIDEIRA CEN01 | REV01	NOVOS ARES AURORA CEN06 | REV00
Torres	4	5	4
Unidades Construídas	390	298	268
Unidades Vendidas	390	294	267
Total Unidades Vendidas	390	294	267
Condomínios (qta.)	1	1	1
Cidade	Goiânia - GO	Goiânia - GO	Goiânia - GO
Produto / Selo	F2 MODULAR	F2 MODULAR	F2 MODULAR
Tipologia	1 Torre | T+4 | 18PP | CS1B	3 Torres | T+4 | 12PP | CS1A	1 Torre | T+3 | 10PP | C1A
Tipologia	2 Torres | T+4 | 20PP | CS1B	1 Torre | T+3 | 12PP | CS1A	1 Torre | T+3 | 12PP | C1A
Tipologia	1 Torre | T+4 | 20PP | LS1B	1 Torre | T+4 | 14PP | CS1A	2 Torres | T+4 | 18PP | C1B
Atributos de Projeto	Piscina	-	-
Projeto Infra	AP	AP	AP
Projeto Torre	AP	AP	AP
Mês Base	junho-25	abril-25	maio-25
Incc	1.184,462	1.184,462	1.184,462
LVS	abril-25	março-25	março-25
Indiretos	abril-25	março-25	março-25
Base de Preço	LPU 91	LPU 90	LPU 90
Takt	2x2	2x2	2+2
Prazo (mês)	13	12	12
CUSTO TOTAL I	R$ / UND R$ 80.571	R$ / UND R$ 90.375	R$ / UND R$ 84.753
Indireto	R$ 16.393	R$ 20.661	R$ 19.078
Torre	R$ 37.222	R$ 39.059	R$ 38.815
Infra	R$ 19.735	R$ 20.063	R$ 19.704
Fundação	R$ 3.916	R$ 7.359	R$ 4.246
EEE	R$ 661		R$ 966
ETE	R$ 1.772	R$ 2.343	
Contenção		R$ 268	R$ 187
Terraplenagem	R$ 872	R$ 622	R$ 1.756
CUSTO TOTAL II	R$ 1.229	R$ 1.830	R$ 3.779
Urbanização			R$ 1.206
Drenagem	R$ 224	R$ 501	R$ 829
Extensão de Rede Elétrica		R$ 172	R$ 562
Extensão de Rede Hidráulica	R$ 1.005	R$ 1.158	R$ 1.182
CUSTO TOTAL III			
Incorridos			
CUSTO TOTAL IV			
Aprendizado			
CUSTO TOTAL V			
Atualização por INCC			
CUSTO TOTAL I+II	R$ 81.800	R$ 92.206	R$ 88.531
CUSTO TOTAL I AO IV	R$ 81.800	R$ 92.206	R$ 88.531

Custo de Construção

	ESTRADA B CEN01 | REV00	VIDEIRA CEN01 | REV01	
Torres	4	5	
Unidades Construídas	390	298	
Unidades Vendidas	390	294	
Total Unidades Vendidas	390	294	
Condomínios (qta.)	1	1	
Cidade	Goiânia - GO	Goiânia - GO	
Produto / Selo	F2 MODULAR	F2 MODULAR	
Tipologia	1 Torre | T+4 | 18PP | CS1B	3 Torres | T+4 | 12PP | CS1A	
Tipologia	2 Torres | T+4 | 20PP | CS1B	1 Torre | T+3 | 12PP | CS1A	
Tipologia	1 Torre | T+4 | 20PP | LS1B	1 Torre | T+4 | 14PP | CS1A	
Atributos de Projeto	Piscina	-	
Projeto Infra	AP	AP	
Projeto Torre	AP	AP	
Mês Base	junho-25	abril-25	
Incc	1184,462	1184,462	
LVS	abril-25	março-25	
Indiretos	abril-25	março-25	
Base de Preço	LPU 91	LPU 90	
Takt	2x2	2x2	
Prazo (mês)	13	12	
CUSTO TOTAL I	R$ / UND R$ 80.571	R$ / UND R$ 90.375	DIF -R$ 9.805
Indireto	R$ 16.393	R$ 20.661	-R$ 4.268
Torre	R$ 37.222	R$ 39.059	-R$ 1.837
Infra	R$ 19.735	R$ 20.063	-R$ 329
Fundação	R$ 3.916	R$ 7.359	-R$ 3.443
EEE	R$ 661	R$ 0	R$ 661
ETE	R$ 1.772	R$ 2.343	-R$ 570
Contenção	R$ 0	R$ 268	-R$ 268
Terrapplenagem	R$ 872	R$ 622	R$ 249
CUSTO TOTAL II	R$ 1.229	R$ 1.830	-R$ 601
Urbanização	R$ 0	R$ 0	R$ 0
Drenagem	R$ 224	R$ 501	-R$ 277
Extensão de Rede Eletrica	R$ 0	R$ 172	-R$ 172
Extensão de Rede Hidráulica	R$ 1.005	R$ 1.158	-R$ 153
CUSTO TOTAL III	R$ 0	R$ 0	R$ 0
Incorridos	R$ 0	R$ 0	R$ 0
CUSTO TOTAL IV	R$ 0	R$ 0	R$ 0
Aprendizado	R$ 0	R$ 0	R$ 0
CUSTO TOTAL V	R$ 0	R$ 0	R$ 0
Atualização por INCC	R$ 0	R$ 0	R$ 0
CUSTO TOTAL	R$ 81.800	R$ 92.206	-R$ 10.406

INDIRETOS

-814 | G11 – Projetos Técnicos (Diluição)
-447 | G14 – Administração (Diluição)
-1.053 | G15 – Implantação do Canteiro (Diluição)
-631 | G16 – Equipamentos (Projeto)
-373 | G17 – Operação do Canteiro (Videira tem escavadeira para hélice)
-812 | G18 – Ensaios (Videira tem ensaio fundação)

TORRE

-126 | Concreto (Projeto)
Estrada B: 18PP 10,41 m³/uh | 20PP 10,37 m³/uh
Videira: 12PP 10,51 m³/uh | 14PP 10,48 m³/uh
-185 | Esquadrias de Ferro (Diluição)
-1.127 | Instalações (LVS 04/25 Estação das Fontes II x LVS 02/25 Média Pq dos Sonhos II e Reserva das Garças x LVS 01/25 Pq dos Sonhos I F1)

INFRA

-633 | Alv. de Vedação (Projeto/Diluição)
-302 | Esq. de Ferro (Projeto/Diluição)
-387 | Paisagismo (Projeto/Diluição)
+954 | Anexos (Estrada B tem piscina)

FUNDAÇÃO

-3.443 | Projeto
Estrada B: Radier com recompactação de 1 a 3m
Videira: Estaca Hélice Ø 30cm - 13m de profundidade

TERRAPLENAGEM

+249 | Projeto
Estrada B: Corte – 1.197 m³ | Aterro – 5.489 m³
Videira: Corte – 3.944 m³ | Aterro – 4.466 m³

Operações

SISTEMA DE ABASTECIMENTO DE ÁGUA
Conforme alinhamento entre a regional e o projetista, foi prevista a extensão de rede de 157 metros.

SISTEMA DE ESGOTAMENTO SANITÁRIO
Conforme alinhamento entre a regional e o projetista, o condomínio contará com uma ETE e seu emissário será destinado para o córrego, com extensão de 420m metros.

SISTEMA DE DRENAGEM
Recomenda-se estender a rede até o trecho urbanizado da Estrada E.

SISTEMA DE ABASTECIMENTO DE GÁS
Abastecimento por GLP.

SISTEMA DE ABASTECIMENTO ELÉTRICO
Existe viabilidade técnica.

TERRENO

URBANIZAÇÃO
Considerado em projeto a execução da calçada da Estrada B e a Estrada E que confrontam o terreno.

Operações

Matriz Risco Concessionária	
Água	Nível 5
Esgoto	Nível 5
Drenagem	NA
Elétrica	Nível 5
Gás	NA
Urbanização	NA

LEGENDA		
Nível	Tipo	Status
1	Com Diretriz	Conclusiva
2		Conclusiva com projeto aprovado
3		Conclusiva sem projeto aprovado
4		Não Conclusiva
5	Sem Diretriz	-
NA	-	Não aplicável

Água:
- Sem viabilidade emitida.

Esgoto:
- Sem viabilidade emitida.

Drenagem:
- O projeto recomenda estender a rede até o trecho urbanizado da Estrada E.

Elétrica:
- Sem viabilidade emitida.
- No pedido de ligação definitiva a concessionária pode vir a cobrar reformas necessárias, caso a infraestrutura existente não seja suficiente.

Gás:
- Empreendimento com GLP.

Urbanização:
- O projeto considera a execução de calçada da Estrada B e Estrada G que confrontam o terreno.

Fundação:
- Realizada campanha de sondagem contemplando 9 furos.
- Considerada Radier, com recompactação de 1 a 3m.

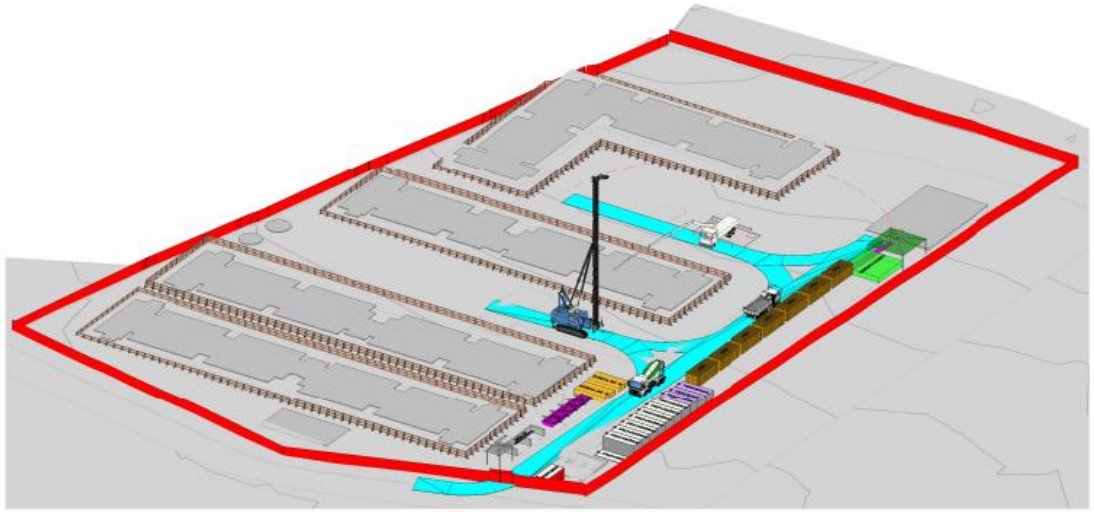

VISTA 3D – PRÉ FORMA

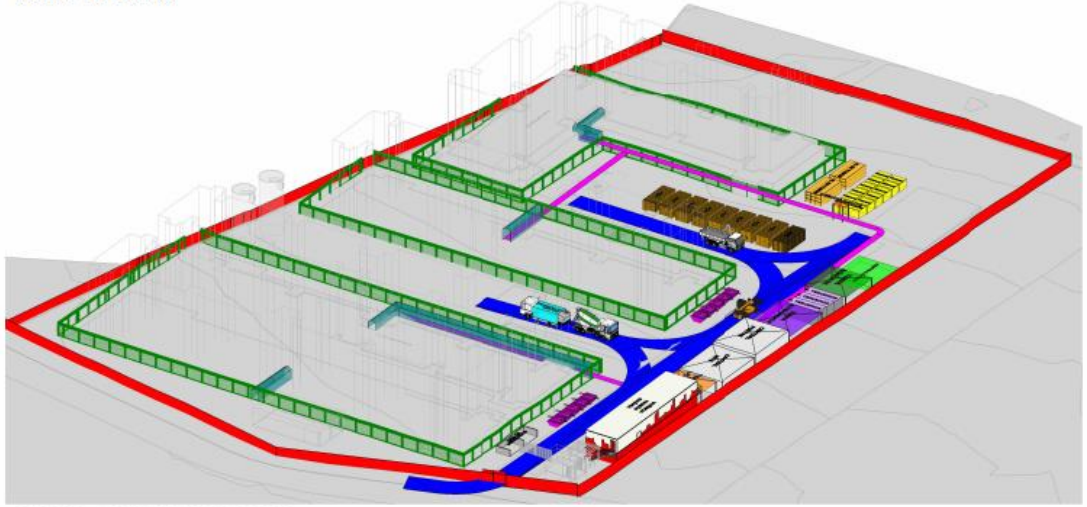

VISTA 3D – ESTRUTURA E ACABAMENTO

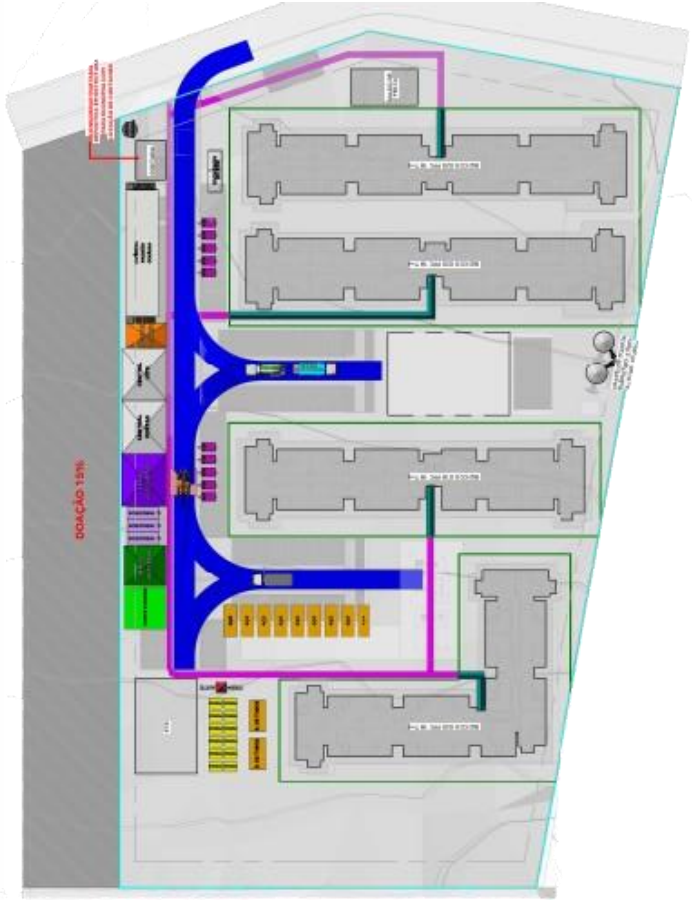

Logística

ITENS A SEREM CONSIDERADOS:

➢ **NEGÓCIOS**	EXECUÇÃO DOS MÓDULOS I E II OCORRERÁ DE FORMA CONCOMITANTE, SENDO QUE O MÓDULO I SERÁ EXECUTADO PELA PRIMEIRA EQUIPE E MÓDULO II PELA SEGUNDA EQUIPE.
➢ **CUSTOS / OBRA**	OBRIGATÓRIA A INSTALAÇÃO DOS CASTELOS D'ÁGUA NA ETAPA DE PRÉ-FORMA PARA EVITAR SEU ENCLAUSURAMENTO APÓS A CONCLUSÃO DA EXECUÇÃO DA PISCINA, POIS NÃO HAVERÁ ACESSO À ESSA ÁREA APÓS O INÍCIO DA ESTRUTURA DESSES BLOCOS.

Pareceres

Análise da Mancha e Implantação

Prospecção

Operações

Inteligência de Mercado

Financeiro

Demanda e Distribuição da Mancha

Potencial de Demanda			Lançados		Lançados + Landbank	
Mancha	CÓD.	Shr.	ANO	MÊS	ANO	MÊS
Goiânia Oeste + Leste	GOO	40%	1.020	85	1.224	102

Empreendimento	Renda	Lançamento	jan/27	fev/27	mar/27	abr/27	mai/27	jun/27	jul/27	ago/27	set/27	out/27	nov/27	dez/27	jan/28	fev/28
Estação Das Fontes IIi - F2	2.203	abr-26	20													
Jardins Do Cerrado F2	2.324	ago-26	24	24	24	24	24	24	24	24	24	17				
Frutas	2.171	nov-26	25	25	25	25	25	25	25	25	25	25	25	20		
Recanto Das Fontes I	2.424	dez-26	10	30	30	30	30	30	30	30	30	30	30	30	30	18
Estrada B	**2.522**	**jan-27**		**30**	**30**	**30**	**30**	**30**	**30**	**30**	**30**	**30**	**30**	**30**	**30**	**30**
Recanto Das Fontes Iv	2.424	jan-28														13
Total de Vendas Lançados			**0**	**0**	**0**	**0**	**0**	**0**	**0**	**0**	**0**	**0**	**0**	**0**	**0**	**0**
Total de Vendas Lançados + Landbank			**79**	**109**	**109**	**109**	**109**	**109**	**109**	**109**	**109**	**102**	**85**	**80**	**60**	**61**

Parecer de I.M sobre a mancha:

O projeto analisado em comitê está em linha com o potencial teórico de demanda calculado para a mancha. (Total Lanç + Landbank)

Canibalização:

Sem Risco de Canibalização

Estrada B | Mapa Concorrência

		Estrada B	Gran Lírio
		TENDA	MRV
	Distância Tenda (km)		1,35km
Região 1 Km	População	9.745	9.556
	Dens. Demográfica	3.122	3.061
	Renda (R$)	4.070	4.358
	Classe Social	C1 (2.7k a 4.6k)	C1 (2.7k a 4.6k)
	PEA Dia	3.944	4.273
Quantitativo	Lançamento	jan/27	out/22
	Unidades	390	432
	Estoque	390	0
	VSO	30	18
Qualitativo	Condomínios	1	1
	Torres	4	18
	Gabarito	T+4	T+4
	Plantas (m²)	32m²	42m²
	Tipologia	2 Dorms	2 Dorms
	Opções	Não	Não
	Varanda	Não	Não
	Suite	Não	Não
	Dif. Entrega	Não	Equipado e Decorado
	Vagas	50% de Vagas	100% de Vagas
	Lazer	Salão De Festas C/ Mini Markt E Churrasqueira, Playkids, Playbaby, Praça Dos Jogos, Piscina, Multipla Estação, Pista De Caminhada, Praça Do Pequi, Roda De Viola, Praça Do Tererê, Praça Do Ipê Do Cerrado E Quadra Gramada P.	Bicicletário, Campo de Futebol, Churrasqueria, Pet Place, Playground, Quadra, Redário,

	Empreendimento	Preço CEF			Gran Lirio	
Tipologias	Tipologia	Sem Vaga	Vaga Moto	Vaga Carro	Sem Vaga	Garden
	Preço Nominal	195.477	199.858	207.969	214.990	229.990
	CEF	157.238	159.234	164.306	171.992	183.992
	Renda	2.250	2.300	2.950	2.750	3.025
	% Unidades	50%	12%	38%	85%	15%
	Dif Renda				500	-
	Farol de Factibilidade				●	●

Farol Renda
Acima de 300
Entre 0 e 300
Abaixo de 0

Diagnóstico Concorrência

- A concorrência possui target de preço e renda acima ao produto Tenda, e já não consta mais em estoque.

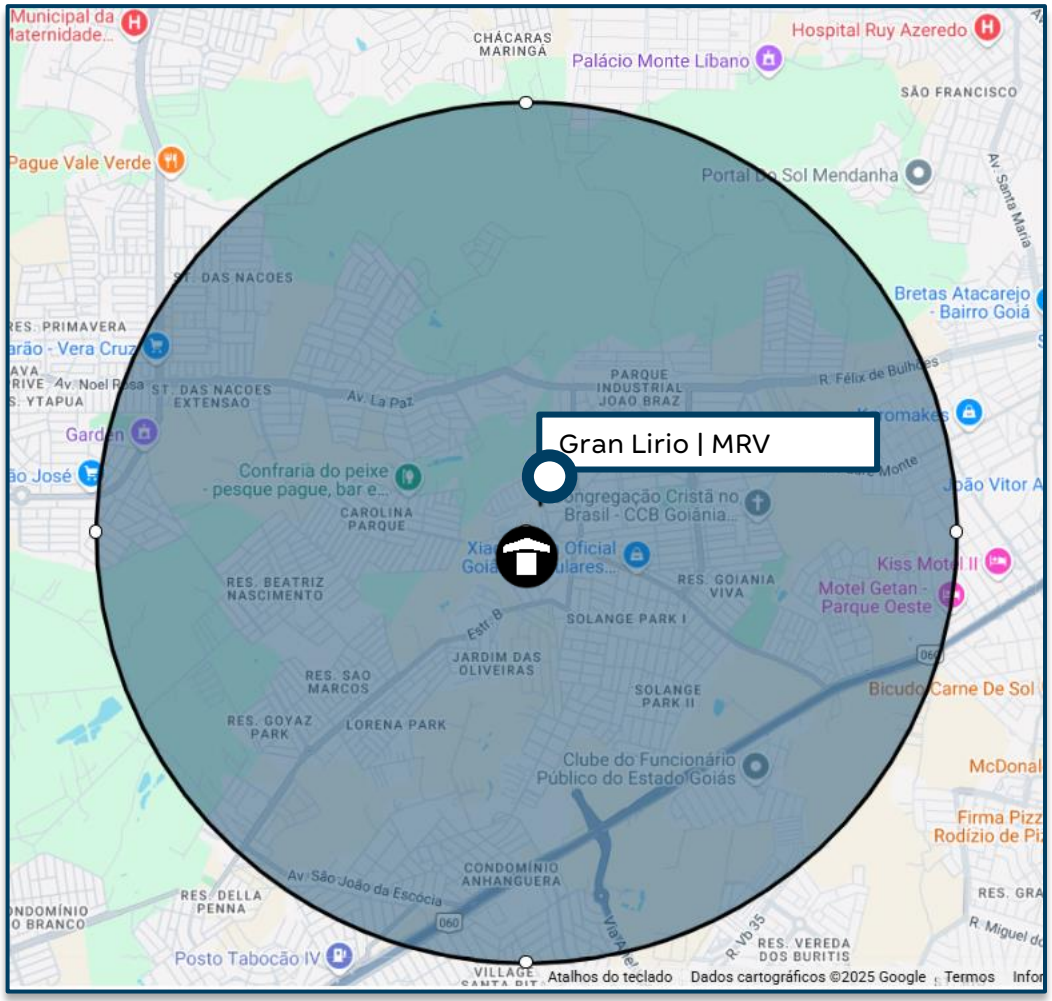

Informações Viabilidade

Projeto:	Estrada B					
Tipo:	**Sem Vaga**		**Vaga Moto**		**Vaga Carro**	
Método	**Vision**		**Vision**		**Vision**	
Avaliação	187.000		192.000		205.000	
Renda Inicial (VF)	2.612		2.768		3.293	
Renda Final*	2.250		2.300		2.950	
% RET1	75%		75%		50%	
Tipo:	**VF**	**R$**	**VF**	**R$**	**VF**	**R$**
Ato	0,48	1.195	0,52	1.368	0,47	1.463
FGTS	0,19	460	0,23	609	0,27	840
Financiamento	99,49%	140.678	98,47%	143.572	101,27%	157.655
Subsídio	98,24%	16.100	120,30%	15.052	141,40%	5.811
Prazo de Pró-soluto	18	18	18	18	18	18
Pró-Soluto	80,99%	13.836	80,99%	14.662	80,99%	17.443
Preço Raso (RS)	172.269	172.269	175.264	175.264	183.212	183.212
TCD	88,15%	23.208	88,15%	24.594	74,59%	24.758
VSO	15	15	4	4	11	11
Preço de Venda	**205.923**	**205.923**	**210.538**	**210.538**	**219.082**	**219.082**
Elasticidade	-5,072%	-5,072%	-5,072%	-5,072%	-5,072%	-5,072%
Preço de Venda Final	**195.477**	**195.477**	**199.858**	**199.858**	**207.969**	**207.969**
Preço Raso (R$)	**172.269**		**175.264**		**183.212**	
% de Raso	**88,13%**		**87,69%**		**88,10%**	
BP25 - Não Inflacionado	-		-		-	
BP25 - Inflacionado	-		-		-	

Análise de Preço

Informações Viabilidade

Projeto:	Estrada B
Tipo:	**Faixa 2**
Método	Vision
Avaliação	194.421
Renda Inicial (VF)	2.889
Renda Final*	2.522

Tipo:	VF	R$
Ato	0,48	1.317
FGTS	0,22	622
Financiamento	100,04%	147.462
Subsídio	117,22%	12.072
Prazo de Pró-soluto	18	18
Pró-Soluto	80,99%	15.302
Preço Raso (RS)	176.775	176.775
TCD	83,00%	23.960
VSO	30	30
Preço de Venda	**210.917**	**210.917**
Elasticidade	-5,072%	-5,072%
Preço de Venda Final	**200.735**	**200.735**
Preço Raso (R$)	**176.775**	
% de Raso	**88,06%**	
Raso Todas as Fases	**176.775**	
Nominal Todas as Fases	**200.735**	

2

1

Análise de Riscos	Farol IM
IM avalia o Preço Vision como **factível**.	

1) I.M está de acordo com o preço Vision, tendo em vista que, o projeto está em uma região com bons indicadores sociodemográficos, como renda e PEA/Dia, em uma região mais centralizada e piscina.
Conforme consta no slide "Panorama de Concorrência", apesar dos concorrentes não terem mais estoque, eles demonstram o perfil da região e que mantemos o affordability em preço e renda.

2) É fundamental que a avaliação seja mantida, a fim de garantirmos o preço estimado pelo Vision.

	Preço Real					Preço Normalizado (18m)		
	Avaliação	Preço Raso	Renda Média	VSO	PSOL	Δ PSOL	Δ Elastic.	Preço Raso
Estação das Fontes	191.242	171.621	2.582	28	7	8.030	-1%	177.513
Estrada B	194.421	176.775	2.889	30	18	-	-	176.775
Lago Azul II	201.707	179.664	2.977	16	13	5.925	-8%	170.123

Estrada B

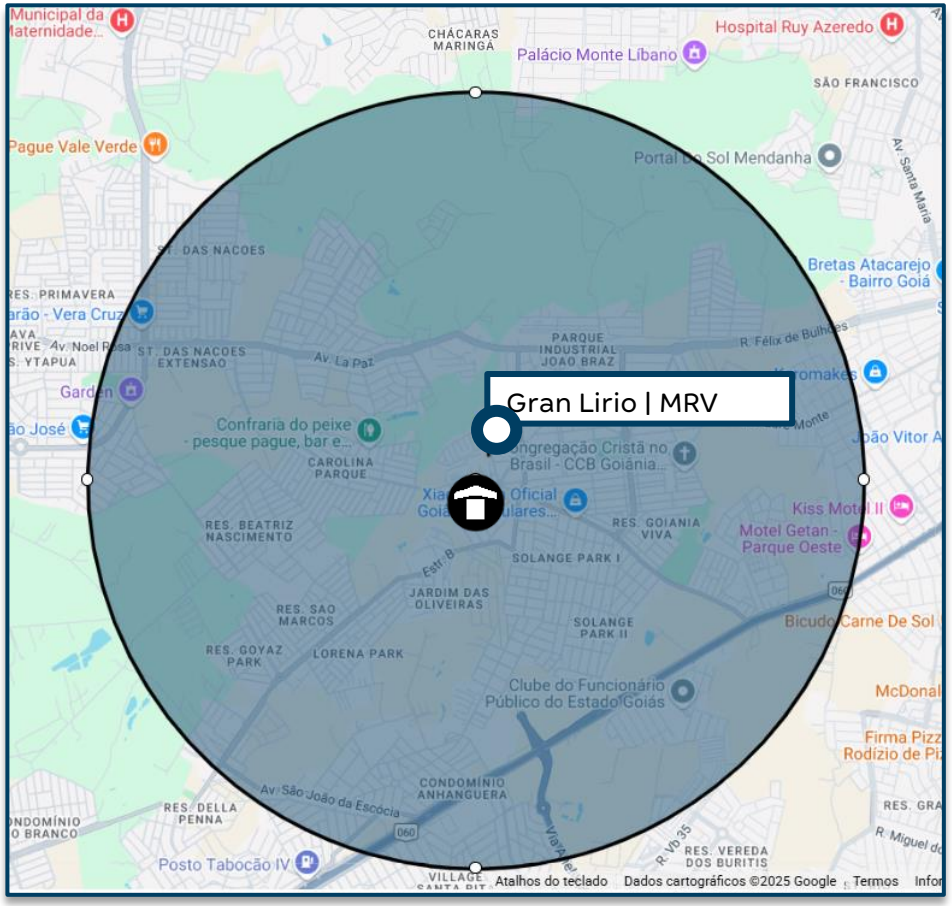

*São considerados apenas as unidades dos concorrentes que estão alinhadas com o produto Tenda

Análise de Riscos	Farol CF
Ciclo Financeiro avalia o Preço Referência como **factível.**	

1) O Ciclo Financeiro está de acordo com a precificação apontada por IM. O produto da concorrência na região praticava uma precificação superior a nossa, empreendimento entregue e sem estoque para venda.

Pareceres

Análise da Mancha e Implantação

Prospecção

Operações

Inteligência de Mercado

Financeiro

Informações Gerais – ESTRADA B

Estrada B - GO - Goiânia Capital

Datas e Prazos

	Compra	Lançamento	Início Obra	Término Obra	LÇTO até IO	IO até TO	Chaves	LÇTO até Chaves
Consolidado	mai-25							
Estrada B c/ vaga carro		jan-27	jul-27	ago-28	6 meses	13 meses	jan-30	36 meses
Estrada B s/ vaga		jan-27	jul-27	ago-28	6 meses	13 meses	jan-30	36 meses
Estrada B c/ vaga moto		jan-27	jul-27	ago-28	6 meses	13 meses	jan-30	36 meses

Terreno e Incorridos

TOTAL (R$ + Perm.):	7,03 MM	**Incorrido Terreno:** 0,00 MM	**Área do Terreno (100%):**	17.579 m²	**Área Líquida do Terreno:** 14.881 m²
Cash:	7,03 MM		**Custo de terreno m²:**	400,0	**Custo de terreno m² Área Líquida:** 472,5
Permuta Financeira:	0,00 MM (0,00%)		**VaR 25 (R$ mil):**	0	**Fração Terreno/Terreno + Custo Obra (%VGV):** 9,0% / 49,7%
Permuta Física:	0,00 MM (0,00%)		**VaR 26 (R$ mil):**	586	**CA Máx/Proj.** 2,0 / 1,0
Ato / %VGV:	0,00 MM / 0,0%		**Incorrido de Construção:**	0,00 MM	**Incorridos de Incorporação:** 0,03 MM

Vendas

Fases	Nº Pavimentos	Preço Raso Unit.	Qtde	Preço Unit.	Aval. CEF	Cond. Parcela	% Pró-soluto	% TCD
Estrada B c/ vaga carro	T+4	183.212	148	207.969	205.000	101,3%	81,0%	74,6%
Estrada B s/ vaga	T+4	172.269	196	195.477	187.000	99,5%	81,0%	88,1%
Estrada B c/ vaga moto	T+4	175.264	46	199.858	192.000	98,5%	81,0%	88,1%

Unidades Totais:	390	**Preço Médio:**	200.735	**Renda Média:**	2.889	**ITBI+Emol. Unit. Médio:**	7.478
Unidades Tenda:	390	**Avaliação Média:**	194.421	**Ato:**	1.390 (0,48 Salários)	**Custo do Ciclo Unit.:**	13.148
VSO:	26 Unidades	**VGV Total:**	78.286.487	**FGTS:**	729 (0,25 Salários)	**Preço Raso Médio:**	176.775
RET Médio:	2,0%	**VGV Tenda:**	78.286.487	**% em RET 1%:**	66%	**Adc. Tx. de Aceleração Médio:**	774

Construção

Custo Total Unit.:	81.800	**Eventuais:**	2,00%	**Área priv (m²):**	31,99	**Gape / Mês Unit.:**	11,08

Resultado

LI (R$):	**11.325.832**	**LI:**	**22,85%**	**Exposição de Caixa (R$):**	**13.248.060**	**Margem Bruta Econômica:**	**43,73%**
TIR:	**140,58%**	**LI Aprovação:**	**20,00%**	**Ger. Caixa 12 meses (R$):**	**0**	**Margem Bruta REF:**	**45,99%**
Exposição de Caixa:	**15,60%**	**Δ LI:**	**2,85%**	**Ger. Caixa 24 meses (R$):**	**(5.489.358)**	**Margem Rasa Econômica:**	**35,43%**
Payback Contingente (21 m):	**15 m/ (-6 m)**	**LI Resiliência:**	**7,81%**	**Ger. Caixa Marginal (R$):**	**24.677.031**	**Margem Rasa REF:**	**38,68%**
Payback Consolidado:	**15 meses**					**Margem de Contribuição Econômica:**	**30,27%**

DRE

R$ Mil - Valores Nominais - Compra	Estrada B		Estrada B c/ vaga carro		Estrada B s/ vaga		Estrada B c/ vaga moto	
	Nominal	%	Nominal	%	Nominal	%	Nominal	%
Receita	84.942	100,0%	33.288	100,0%	41.646	100,0%	10.008	100,0%
PIS/COFINS	(951)	1,1%	(456)	1,4%	(399)	1,0%	(96)	1,0%
Custo Total	(47.258)	56,3%	(17.920)	54,6%	(23.745)	57,6%	(5.593)	56,4%
Custo Terreno	(7.974)	9,5%	(3.026)	9,2%	(4.007)	9,7%	(940)	9,5%
Custo Relacionados a Terreno	(429)	0,5%	(163)	0,5%	(215)	0,5%	(51)	0,5%
Custos de Incorporação	(1.260)	1,5%	(464)	1,4%	(628)	1,5%	(168)	1,7%
Custo de Construção	(37.597)	44,8%	(14.267)	43,5%	(18.895)	45,8%	(4.434)	44,7%
Lucro Bruto Econômico	36.733	43,7%	14.912	45,4%	17.502	42,4%	4.319	43,6%
Custo para Rateio	-	0,0%	-	0,0%	-	0,0%	-	0,0%
Lucro Bruto Contábil	36.733	43,7%	14.912	45,4%	17.502	42,4%	4.319	43,6%
Despesas de Selling	(9.357)	11,1%	(3.655)	11,1%	(4.603)	11,2%	(1.099)	11,1%
Contingência	(1.954)	2,3%	(766)	2,3%	(958)	2,3%	(230)	2,3%
Margem de Contribuição	25.422	30,3%	10.491	32,0%	11.941	29,0%	2.990	30,2%
IR e CSLL	(778)	0,9%	(373)	1,1%	(327)	0,8%	(78)	0,8%
Margem Líquida	24.644	29,3%	10.118	30,8%	11.615	28,2%	2.912	29,4%
Lucro Bruto REF Unit.	101.637	46,0%	110.117	47,9%	96.248	44,5%	100.815	45,7%
Lucro Raso REF Unit.	75.186	38,7%	82.774	40,8%	70.623	37,1%	73.713	38,1%

R$ Mil - VPL - Compra	Estrada B		Estrada B c/ vaga carro		Estrada B s/ vaga		Estrada B c/ vaga moto	
	VP	%	VP	%	VP	%	VP	%
Receitas	49.557	100,0%	19.390	100,0%	24.320	100,0%	5.847	100,0%
PIS/COFINS	(546)	1,1%	(261)	1,3%	(230)	0,9%	(55)	0,9%
Custos e Despesas Totais	(37.685)	76,0%	(14.409)	74,3%	(18.822)	77,4%	(4.455)	76,2%
Custo Terreno	(5.278)	10,6%	(2.003)	10,3%	(2.652)	10,9%	(623)	10,6%
Custo Relacionados a Terreno	(338)	0,7%	(128)	0,7%	(170)	0,7%	(40)	0,7%
Custos de Incorporação	(901)	1,8%	(333)	1,7%	(448)	1,8%	(120)	2,0%
Custo de Construção	(23.726)	47,9%	(9.004)	46,4%	(11.924)	49,0%	(2.798)	47,9%
Despesas de Selling	(6.362)	12,8%	(2.478)	12,8%	(3.129)	12,9%	(755)	12,9%
Contingência	(634)	1,3%	(248)	1,3%	(311)	1,3%	(75)	1,3%
IR e CSLL	(447)	0,9%	(214)	1,1%	(188)	0,8%	(45)	0,8%
Lucro Imobiliário	11.326	22,9%	4.720	24,3%	5.269	21,7%	1.337	22,9%

Obrigado