Tenda

sua próxima conquista

Book de Investimento

Regional: PB

Projeto: Altiplano Sunset

Data Comitê: 10/02/2025

Atualização de Material

Comparativo dos Estudos - Consolidado	Anterior	Atual	Atual vs Anterior	Δ%
Data Estudo:	fevereiro-25	fevereiro-25	0 Meses	N/A
Lançamento:	fevereiro-26	fevereiro-26	0 Meses	N/A
Custo Total Inf (uh):	148.163	148.682	519	0,4%
Custo Terreno:	16.252.612	16.770.885	518.273	3,2%
Custo Relacionados a Terreno (uh):	1.224	1.015	(208)	-17,0%
Lucro Imobiliário:	20,0%	20,0%	-0,1 p.p.	-0,3%
LI Resiliência:	14,2%	14,2%	0,0 p.p.	0,0%
Exposição de caixa:	6,5%	6,4%	-0,1 p.p.	-1,3%
TIR:	108,3%	111,1%	2,8 p.p.	2,6%
Margem Bruta REF:	42,0%	41,8%	-0,2 p.p.	
Margem Bruta Econômica:	38,7%	38,5%	-0,2 p.p.	-0,6%
Margem Rasa REF:	35,3%	35,1%	-0,2 p.p.	
Margem Rasa Econômica:	30,9%	30,6%	-0,2 p.p.	-0,8%
Margem Contribuição Econômica:	27,6%	27,3%	-0,2 p.p.	-0,8%
Payback Contingente (Régua 21 m):	19 m/ (-2 m)	19 m/ (-2 m)	0	0,0%
Payback Consolidado:	19 Meses	19 Meses	0 Meses	0,0%

Atualização do fluxo da quitação da Permuta. (-0,19 p.p.)
Atualização da Corretagem de 5% para 4% (-0,06 p.p..)

Comentários Comitê 10/02/25

Nome	Altiplano Sunset - Investimento	Observação - Altiplano Sunset
Andre Luis Menegazzo Padilha	Aprovado	ok
Fabricio Quesiti Arrivabene	Aprovado	Atenção apenas em relação a termos muitos projetos concomitantes, antes do conhecimento pleno da regional.
Alexandre Regis de Oliveira	Aprovado	ok
Alejandro Octavio Abiusi	Aprovado	ok
Luiz Mauricio de Garcia Paula	Discutir em Comitê	não existe nenhuma alternativa para cobrar pelas vages de carro e moto? Qual a restrição para que elas sejam vendidas individualmente?
Renan Barbosa Sanches	Aprovado	Ok
Amanda da Silva Bezerra	Aprovado	ok
Rodrigo Osmo	Discutir em Comitê	(1) O valor da quitação da permuta, que ocorre 36 meses após o habite-se (que imagino que seja da última fase), será de R$14,5M ou a estimativa do saldo a receber do permutante? Se for estimativa do saldo a receber, é um valor maior do que o que estaria na viabilidade, caso essa estimativa não contemple inadimplência da carteira;

Fabricio Quesiti Arrivabene

Pergunta: Atenção apenas em relação a termos muitos projetos concomitantes, antes do conhecimento pleno da regional.

Resposta: Estamos estrategicamente compondo opcionalidades de terrenos para, no momento do lançamento, fazer a escolha mais estratégica

Comentários Comitê 10/02/25

Luiz Mauricio de Garcia Paula

Pergunta: não existe nenhuma alternativa para cobrar pelas vages de carro e moto? Qual a restrição para que elas sejam vendidas individualmente?

Resposta: Não há nenhuma restrição. Estamos apresentando ao comitê de investimento o cenário mais conservador e, no momento do lançamento, buscaremos maximizar o valor com a venda das vagas.

Rodrigo Osmo

Pergunta:(1) O valor da quitação da permuta, que ocorre 36 meses após o habite-se (que imagino que seja da última fase), será de R$14,5M ou a estimativa do saldo a receber do permutante? Se for estimativa do saldo a receber, é um valor maior do que o que estaria na viabilidade, caso essa estimativa não contemple inadimplência da carteira;

Resposta: A quitação ocorrerá 36 meses após a emissão do Habite-se da fase 2, última etapa do empreendimento. O valor corresponde à estimativa do saldo a receber do permutante, considerando o contas a receber sem o desconto da inadimplência e sem desconto a valor presente. Será pago 9,3% desse saldo, resultando em um montante superior ao previsto na viabilidade financeira (VF), que já considera inflação e inadimplência. Ajustamos a VF, os números financeiros atualizados seguem abaixo.

Rodrigo Osmo

Pergunta:(1) O valor da quitação da permuta, que ocorre 36 meses após o habite-se (que imagino que seja da última fase), será de R$14,5M ou a estimativa do saldo a receber do permutante? Se for estimativa do saldo a receber, é um valor maior do que o que estaria na viabilidade, caso essa estimativa não contemple inadimplência da carteira;

Comparativo dos Estudos - Consolidado	Anterior	Atual	Atual vs Anterior	Δ%
Data Estudo:	fevereiro-25	fevereiro-25	0 Meses	N/A
Lançamento:	fevereiro-26	fevereiro-26	0 Meses	N/A
Custo Total Inf (uh):	148.163	148.682	519	0,4%
Custo Terreno:	16.252.612	16.770.885	518.273	3,2%
Custo Relacionados a Terreno (uh):	1.224	1.015	(208)	-17,0%
Lucro Imobiliário:	20,0%	20,0%	-0,1 p.p.	-0,3%
LI Resiliência:	14,2%	14,2%	0,0 p.p.	0,0%
Exposição de caixa:	6,5%	6,4%	-0,1 p.p.	-1,3%
TIR:	108,3%	111,1%	2,8 p.p.	2,6%
Margem Bruta REF:	42,0%	41,8%	-0,2 p.p.	
Margem Bruta Econômica:	38,7%	38,5%	-0,2 p.p.	-0,6%
Margem Rasa REF:	35,3%	35,1%	-0,2 p.p.	
Margem Rasa Econômica:	30,9%	30,6%	-0,2 p.p.	-0,8%
Margem Contribuição Econômica:	27,6%	27,3%	-0,2 p.p.	-0,8%
Payback Contingente (Régua 21 m):	19 m/ (-2 m)	19 m/ (-2 m)	0	0,0%
Payback Consolidado:	19 Meses	19 Meses	0 Meses	0,0%

One Page – Altiplano Sunset

[1]

Cidade	João Pessoa	**Mancha de demanda**	PB - JPE - João Pessoa
Regional	PB	**Cluster MPR**	3 - Verde
Cenário de Aprovação	Aprovação	**Tipo de Aprovação**	Consolidado
Fase Anterior	N/A		
Tipo de Comitê	Investimento	**Versão da VF**	Versão 1.0: Fev

[2]

Unidades (% Vagas)	712 (35%)	**CA Máx | Proj**	4,0 | 2,5
Tipologia	F2E - Concreto	**Escritura**	dez-25
Fases	2 fases	**Lçto | Duração (m)**	fev/26 | 41

[3]

Valor Terreno (% VGV)	14.839 (9,3%)	**Un. Perm. Fís (% Ter)**	0 (0,0%)
Cash (Correção)	0 (N/A)	**%VGV Perm Fin (% Ter)**	9,3% (100,0%)
Valor R$/m²	1.035	**VAR (%VGV)**	000 (0,0%)

[4]

Custo Construção (%VGV)	69.445 (43,5%)	**Indireto Unit.**	19.911
Prazo da Obra (meses)	17	**Torre Unit.**	55.250
Custo Total Unit. (LPU):	97.536 (LPU86)	**Infra Unit.**	12.363
Início de Obra	ago-26	**Fundação Unit.**	6.370

[5]

Preço Nominal Unit.	224.103	**VSO**	20
Preço Raso Unit.	201.035	**Referência**	VISION
Avaliação Unit.	239.775	**Renda (% em RET 1%)**	3.204 (38,1%)

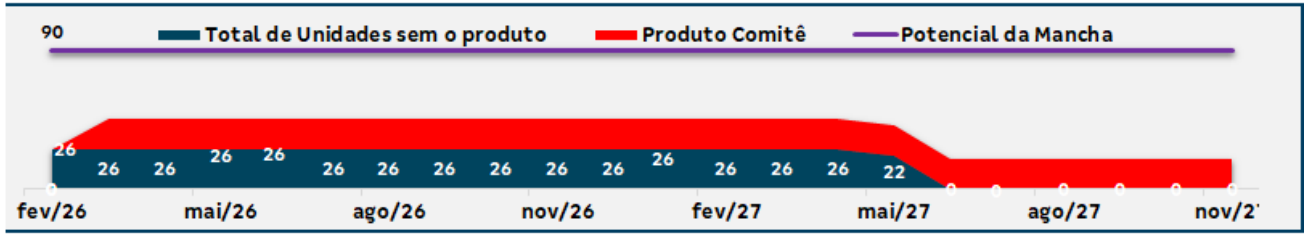

LI (Régua):	**20,0% (20,0%)**	**Margem Bruta Econômica:**	38,5%
LI Resiliência:	14,2% (N/A)	**Margem Rasa Econômica:**	30,6%
Margem Bruta REF:	41,8%	**Margem Contribuição Econômica:**	27,3%
Margem Rasa REF:	**35,1%**	**Exposição (% VGV):**	11.267 (6,4%)
TIR:	111,1%	**VGV Total:**	159.562
Payback Contingente (21 m) :	**19 m/ (-2 m)**	**Ger. Caixa 12 meses (R$):**	(1.983)
Payback Consolidado:	19	**Ger. Caixa 24 meses (R$):**	(10.622)

Destaques

[1] Terreno

- Situado no bairro Portal do Sol, em região bem próxima a praia de Cabo Branco (1,4Km), sendo esta um dos principais cartões postais da cidade e principal polo turístico. Tendo em vista a cota de implantação, os apartamentos dos últimos andares do bloco 04 deverão ter vista-mar. Localizada a 600m da Av. Antonio da Silva Mariz, que liga os principais acessos das regiões litorâneas a zona sul de João Pessoa, tendo ainda proximidade de pontos de comércio, como mercearias, farmácias, escolas e outros.

[2] Produto

- Apesar do coeficiente de adensamento máximo de 4,0, devido a área de APP e declividade acentuada aos fundos do lote, tendo ainda a necessidade de implantarmos vagas mínimas de carro, moto e via interna para acesso a estas vagas, atingimos o potencial máximo de adensamento em 2,5, com 04 torres em T+17 (que é a altura máxima de verticalização da regional).
- O empreendimento contará com vagas rotativas de carro (143) e moto (108), piscina adulto e infantil e varanda, estando elas em uma face de cada torre. As unidades possuem 39,03m².
- Projeto Faseado buscando equilíbrio entre nº de uh's x custo sem deixar de cumprir a regra de ouro de esgotamento.

[3] Condição do Negócio

- R$ 15.166.800,00, conforme PCV, sendo o valor meramente fiscal e estimativo
- * VF considera valor de R$ 14.839.000 (quatorze milhões e oitocentos e trinta e nove mil reais), equivalente a 9,3% do VGV, após correção de unidades vindas no anteprojeto;
- 100% Permuta Financeira
- Contrato exige o pagamento de R$ 14.500.000 (quatorze milhões e quinhentos mil reais) como valor mínimo de apuração de permuta, a ser finalizado em até 36 meses **após habite-se** do empreendimento. Este valor equivale a um preço médio, aprox., de R$ 219 mil/uh.

[4] Custo

- Custo parametrizado de jan/25. Tivemos uma reunião presencial com Rafaelli Silva da CAGEPA (concessionária de água e esgoto do Estado da Paraíba), responsável pela emissão das viabilidades de água e esgoto da concessionária, que nos informou ter água a 300m da testada do terreno com dimensionamento adequado ao nosso projeto. Estamos seguindo com o custo considerando ETE para sermos conservadores, pois nesta reunião não foi possível dimensionar a solução do esgoto, por necessidade de maiores informações técnicas (declividade, diâmetros de rede e pontos de coleta).

[5] Precificação

- Precificação VISION, seguindo regra de ouro.

- Pareceres
- Análise da Mancha e Implantação
- Prospecção
- Operações
- Inteligência de Mercado
- Financeiro

Parecer – Altiplano Sunset

Área	Riscos Associados	Parecer	Criticidade
Jurídico	**a) Due Diligence do Imóvel** - Em andamento, previsão de conclusão em fev/25: i) Negócio é constituído de 01 imóvel do 2º Registro Geral de Imóveis de João Pessoa/PB, o qual precisará ser retificado; ii) As certidões de desapropriação municipal e estadual do imóvel estão pendentes, cuja emissão está em andamento; iii) Imóvel possui débitos de IPTU de valor irrisório. Pela PVC, cabe aos proprietários realizarem a emissão da CND até o momento da escritura definitiva para a Tenda; iv) Imóvel possui hipoteca registrada em sua matrícula, a qual, pela PVC, deve ser cancelada pela vendedora antes da escritura definitiva; v) Há duas ações possessórias em andamento em relação ao imóvel de interesse a Tenda. Há sentença favorável à vendedora em um deles, estando a vendedora imitida na posse, o que contribui para reduzir os riscos. De acordo com a PVC, é responsabilidade da Vendedora garantir o arquivamento do processo até a lavratura da Escritura para a Tenda. vi) Houve procedimento administrativo proposto pela antecessora do imóvel em face do cartório de notas que lavrou o título aquisitivo anterior, discutindo irregularidades administrativas na elaboração do título aquisitivo da antecessora. Apesar disso, o título foi registrado no cartório de imóveis, permanecendo firme e sem questionamento por mais de 12 anos. A análise jurídica aprofundará este item, cujo risco fica minorado pela: (a) inexistência de discussão sobre a cadeia sucessória; (b) inexistência de discussão sobre a declaração de vontade e/ou conteúdo da transmissão, sendo a antecessora a legítima titular do imóvel; (c) lavratura e registro de compra e venda posterior entre a antecessora e a atual vendedora; (d) tempo de posse que impediria eventual decretação nulidade. **b) Due Diligence dos pesquisados -** Em andamento, previsão de conclusão em fev/25: i) Levantamento de patrimônio e passivo da Vendedora está em andamento. ii) Não foram verificados, até o presente momento, processos que tenham por objeto o Imóvel pretendido pela Tenda. Há processo trabalhista em que a vendedora foi incluída em grupo econômico. O processo em si não impõe risco ao negócio, tendo havido acordo, cujo pagamento está em andamento. Assim, até o presente, os processos não impõem risco ao negócio jurídico almejado; iii) Há certidões fiscais da vendedora pendentes, as quais são necessárias para a escritura, devendo ser apresentadas pela vendedora antes da escritura para a TENDA, conforme PVC; iv) PVC assinada em maio/24.	Com ressalvas	
Legalização	Para a implantação do empreendimento, será necessária a retificação da matrícula do imóvel, uma vez que o georreferenciamento atual não corresponde à realidade. No lote destinado ao empreendimento, há a incidência de uma área classificada como Zona de Proteção Ambiental (ZEPA-2). Esse zoneamento impõe restrições ao uso e à ocupação, sendo sua aprovação condicionada à anuência da Secretaria de Meio Ambiente (SEMAM) e à possível aplicação de medidas mitigadoras, conforme a legislação ambiental vigente. No entanto, essas restrições serão avaliadas apenas no momento do licenciamento do empreendimento. Ressalta-se que o Estudo de Viabilidade Ambiental não identificou impedimentos relevantes ao uso do terreno. Ademais, não haverá construções nesse trecho, que será integralmente preservado.	Ok	
Produto	Ok	Ok	
GETEC	Custo realizado com a tipologia de CE. Sem diretriz de água e esgoto, conforme reunião realizada entre Regional e CAGEPA, temos viabilidade para o empreendimento na ligação de água em, aproximadamente, 300m. Quanto ao esgoto, seguimos com ETE, para custo conservador. Após a chegada das diretrizes, este custo deverá ser revisado.	Com ressalvas	
Logística	Sem riscos associados	Ok	
Contratação	N/A	Ok	
Inteligência de mercado	IM avalia preço e VSO como factível	Ok	
Comercial/Ciclo	Ciclo avalia preço e VSO como factível	Ok	
Estudos Econômicos	Sem riscos associados	Ok	

Pareceres

Análise da Mancha e Implantação

Prospecção

Operações

Inteligência de Mercado

Financeiro

Mancha de Demanda

MANCHAS DE DEMANDA
• JP – João Pessoa

LandBank

1. Reserva dos Colibris
2. Altiplano

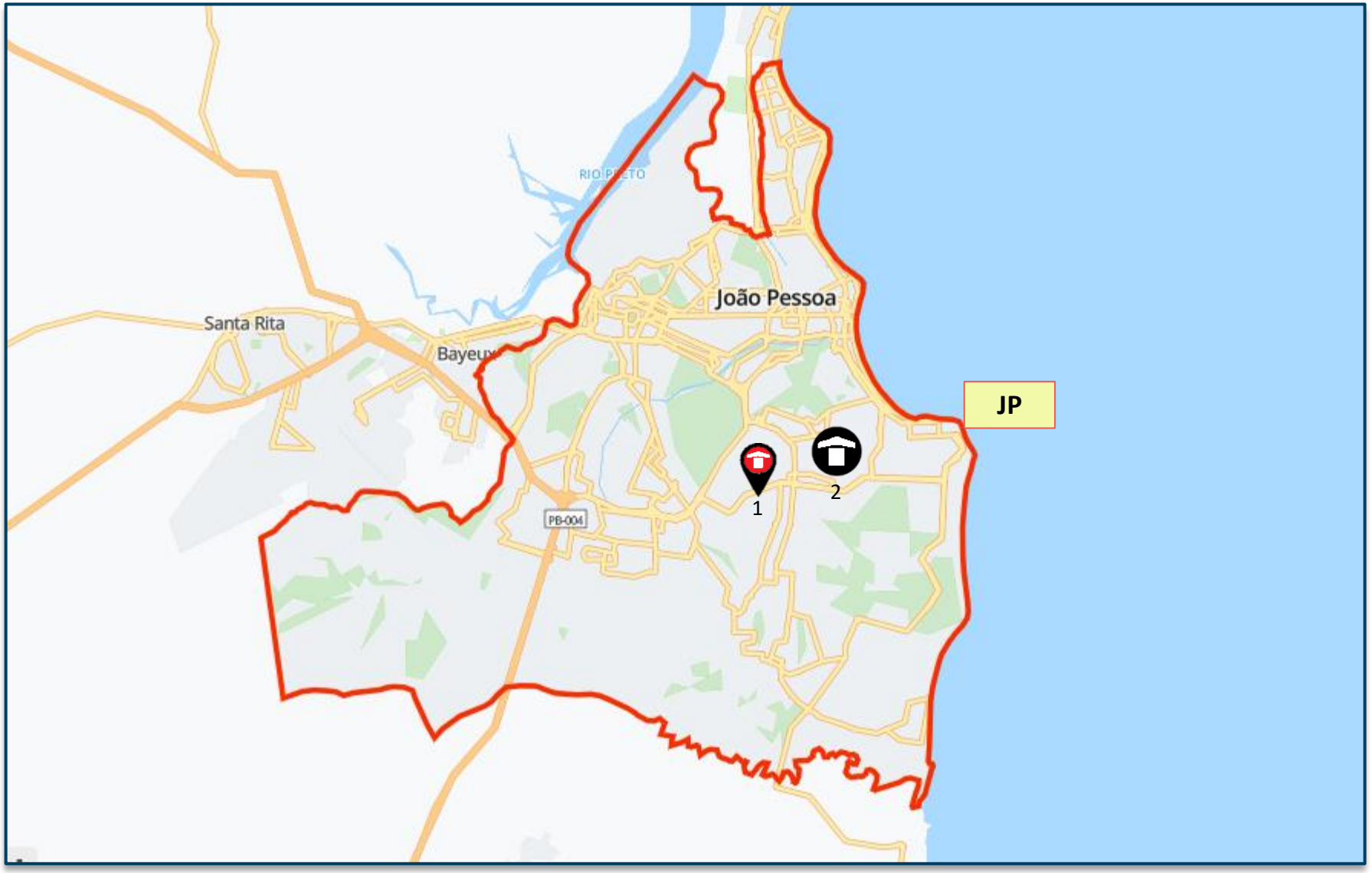

Cluster MPR – (Comitê)
● Cluster 3 - Verde

Região
Capital

Lançados *LandBank* *Comitê*

PRODUTO

Empreendimento Altiplano Sunset

Informações Gerais – Condomínio Único		
Terreno	Área terreno	19.342,61m²
	Menor poligonal	19.342,61m²
	App/fna	APP = 5.007,29M²
	Reserva de calçada/ melhoramento víario	Não
	Área liquida	14.335,32m²
	Zoneamento	ZONA HABITACIONAL - 4
	Ca máximo	4,00
	Ca projetado*	1,44
	Gabarito máximo	150m (T+25)
Geral	Total uh	712
	Total de vagas (auto|motos)	142 (20%) | 108 (15%)
Tipologia	Tipologia	Modular com elevador
	Gabarito	T+17
	Lâmina	10PP
	Área privativa	39,03 m²
Condomínio	Unidade pcd	24
	Unidade lazer	4
	Torre	4
	Fase	Cond. Faseado
Lazer	Lazer coberto	Espaço Office, Churrasqueira Gourmet, Brinquedoteca, Salão de Festas.
	Lazer descoberto	Piscina adulto e infantil, Fitness Externo.

**CA LÍQUIDO = 2,53*

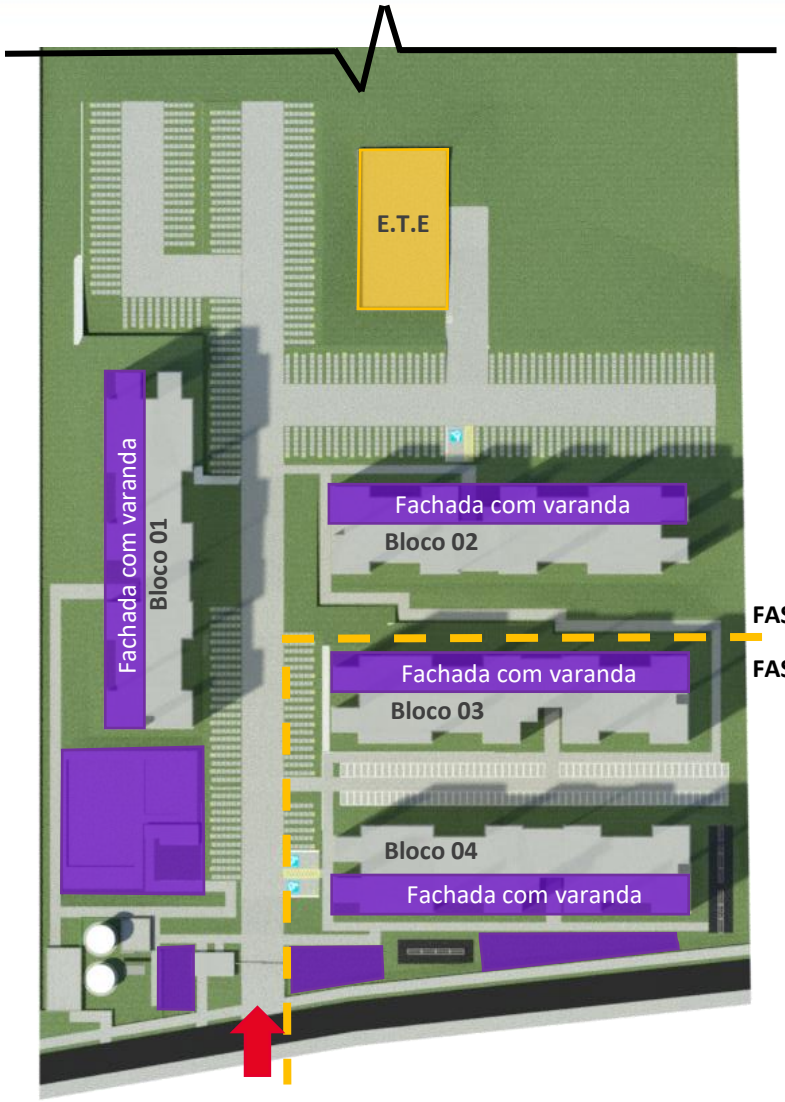

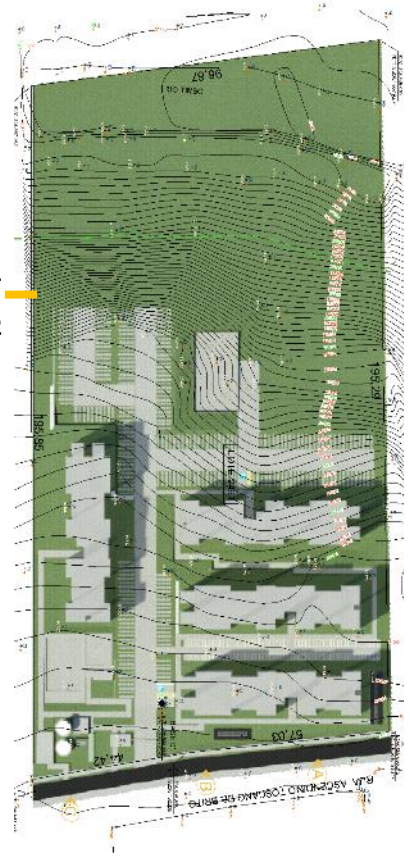

IMPLANTAÇÃO

PRODUTO

Empreendimento Altiplano Sunset

	Descrição	Criticidade	Parecer
Usabilidade	**Limite supercondomínio**		
	Acesso		
	Percurso do pedestre até torre		Desnível de 7m até a ultima torre
Diferencial produto	**Atributos Infra**	Sim	Piscina
	Atributos Torre	Sim	% de UH com varanda
	Edifício Garagem	Não	

Implantação Geral

Declividade/APP

Piscina Adulto e Infantil

Pareceres

Análise da Mancha e Implantação

Prospecção

Operações

Inteligência de Mercado

Financeiro

Condições do Negócio

➢ **VALOR DO NEGÓCIO**
- R$ 15.166.800,00 (PCV a título meramente fiscal e estimativo).

➢ **CONDIÇÃO**
- 100% Permuta Financeira

➢ **FORMA DE PAGAMENTO**
- a) R$ 15.166.800,00 a ser pago em permuta financeira, equivalente a 9,3% sobre a receita bruta do empreendimento.

- * Em viabilidade, o valor do negócio passou a ser R$ 14.835.000,00 em função da atualização do número de unidades após emissão do Anteprojeto.
- ** Contrato exige o valor mínimo de apuração de permuta em R$ 14.500.000,00, equivale a um preço médio, aprox., de R$ 219 mil/uh

➢ **PRAZOS CONTRATUAIS**
- Ocorrendo a desistência da incorporação, após a escritura, teremos o prazo para relançar em até 12 (doze) meses desta desistência, podendo a permutante resolver o negócio após este prazo, caso não queira aguardar o novo lançamento, sem penalidade às partes.;
- Assinatura da ECV em 18 meses após PCV (prazo final para dez/25, contando assinatura da PCV em jun/24;
- Quitação da Permuta Financeira deverá ocorrer em até 36 meses após o habite-se do empreendimento.

➢ **GARANTIAS**
- Tenda: N/A;
- Vendedor: Escritura Pública de Novação e Confissão de Dívida.

➢ **CORREÇÃO MONETÁRIA**
- N/A

➢ **INTERMEDIAÇÃO IMOBILIÁRIA**
- Comissão de responsabilidade da Tenda.
- Será pago valor proporcional, totalizando a intermediação em **4,0%** do valor do negócio, para as empresas: SEMPRE - MASUR SOLUÇÕES EMPRESARIAIS LTDA, MM NEGOCIOS IMOBILIARIOS LTDA e MC INTERNACIONAL COMÉRCIO DE IMÓVEIS LTDA em até 30 dias após a data da outorga da escritura.

➢ **OUTRAS INFORMAÇÕES**
- Assinatura do contrato: jun/2024;
- Previsão de assinatura da corretagem imobiliária: fev/25;
- Previsão de assinatura de Escritura: dez/2025;
- Previsão de Lançamento: fev/2026

- Pareceres
- Análise da Mancha e Implantação
- Prospecção
- Operações
- Inteligência de Mercado
- Financeiro

Custo de Construção

	ALTI PLANO PRIME CEN1 | R01 CONSOLIDADO	ALTI PLANO PRIME CEN1 | R00 CONSOLIDADO	RESERVA DOS COLIBRIS CEN1 | R02	RESERVA DOS COLIBRIS CEN1 | R01	MANDACARU ESTUDO PB
Torres	4	4	2	2	2
Unidades Construídas	360 | 360	360 | 360	468	468	288
Unidades Vendidas	356 | 356	356 | 356	464	464	285
Total Unidades Vendidas	712	712	464	464	285
Condomínios (qta.)	1	1	1	1	1
Cidade	JOÃO PESSOA - PB	JOÃO PESSOA - PB	JOÃO PESSOA - PB	JOÃO PESSOA - PB	JOÃO PESSOA - PB
Produto / Selo	F2E MODULAR - TORRE CE GRA	F2E MODULAR - TORRE CE GRA	F2E MODULAR - TORRE CE GRA	F2E MODULAR - TORRE CE GRA	F2E MODULAR - TORRE CE GRA
Tipologia	4 Torres | T+17 | 10PP | CE2A	4 Torres | T+17 | 10PP | CE2A	1 Torres | T+17 | 12PP | CE1A	1 Torres | T+17 | 12PP | CE1A	1 Torre | T+15 | 8PP | C1A
Tipologia	-	-	1 Torres | T+17 | 14PP | CE1A	1 Torres | T+17 | 14PP | CE1A	1 Torre | T+15 | 10PP | C2A
Atributos de Projeto	VARANDA / PISCINA	PISCINA	VARANDA / PISCINA	VARANDA / PISCINA	PISCINA
Projeto Infra	AP	AP	AP	AP	AP
Projeto Torre	AP	AP	AP	AP	AP | LO
Mês Base	janeiro-25	outubro-24	janeiro-25	janeiro-25	julho-24
Incc	1.159,536	1.141,398	1.159,536	1.159,536	1.118,827
LVS	outubro-24	agosto-23	novembro-24	novembro-24	maio-24
Indiretos	dezembro-24	agosto-23	novembro-24	novembro-24	maio-24
Base de Preço	LPU 86	LPU 83	LPU 86	LPU 86	LPU 80
Takt	2x2	2x2	2x2	2x2	2x2
Prazo (mês)	17 | 16	16 | 15	19	19	16
CUSTO TOTAL I	R$ / UND R$ 96.733	R$ / UND R$ 101.393	R$ / UND R$ 100.213	R$ / UND R$ 101.506	R$ / UND R$ 98.834
Indireto	R$ 19.911	R$ 19.387	R$ 18.654	R$ 19.098	R$ 21.243
Torre	R$ 55.250	R$ 57.060	R$ 56.580	R$ 56.580	R$ 55.423
Infra	R$ 12.363	R$ 14.300	R$ 13.959	R$ 14.455	R$ 16.076
Fundação	R$ 6.370	R$ 6.562	R$ 7.294	R$ 7.384	R$ 5.574
EEE	R$ 104	R$ 193	R$ 159	R$ 159	
ETE	R$ 1.187	R$ 2.205	R$ 1.818	R$ 1.818	
Contenção	R$ 741	R$ 800	R$ 52	R$ 52	
Terraplenagem	R$ 809	R$ 886	R$ 1.697	R$ 1.959	R$ 518
CUSTO TOTAL II	R$ 802	R$ 320	R$ 744	R$ 1.047	R$ 798
Urbanização	R$ 315	R$ 320	R$ 364	R$ 371	R$ 394
Drenagem	R$ 149	Sem diretriz	R$ 380		R$ 19
Extensão de Rede Elétrica	R$ 84	Sem diretriz			R$ 351
Extensão de Rede Hidráulica	R$ 254	Sem diretriz	R$ 0	R$ 677	R$ 34
CUSTO TOTAL III					
Incorridos					
CUSTO TOTAL IV					
Aprendizado					
CUSTO TOTAL V		R$ 1.616			R$ 3.625
Atualização por INCC		R$ 1.616			R$ 3.625
CUSTO TOTAL I+II	R$ 97.535	R$ 101.712	R$ 100.957	R$ 102.553	R$ 99.632
CUSTO TOTAL I AO V	R$ 97.535	R$ 103.328	R$ 100.957	R$ 102.553	R$ 103.257

Custo de Construção

	ALTI PLANO PRIME CEN1 | R01 CONSOLIDADO	ALTI PLANO PRIME CEN1 | R00 CONSOLIDADO	
Torres	4	4	
Unidades Construídas	360 | 360	360 | 360	
Unidades Vendidas	356 | 356	356 | 356	
Total Unidades Vendidas	712	712	
Condomínios (qta.)	1	1	
Cidade	JOÃO PESSOA - PB	JOÃO PESSOA - PB	
Produto / Selo	F2E MODULAR - TORRE CE GRA	F2E MODULAR - TORRE CE GRA	
Tipologia	4 Torres | T+17 | 10PP | CE2A	4 Torres | T+17 | 10PP | CE2A	
Tipologia	-	-	
Atributos de Projeto	VARANDA / PISCINA	PISCINA	
Projeto Infra	AP	AP	
Projeto Torre	AP	AP	
Mês Base	janeiro-25	outubro-24	
Incc	1159,536	1141,398	
LVS	outubro-24	agosto-23	
Indiretos	dezembro-24	agosto-23	
Base de Preço	LPU 86	LPU 83	
Takt	2x2	2x2	
Prazo (mês)	17 | 16	16 | 15	
CUSTO TOTAL I	R$ / UND R$ 96.733	R$ / UND R$ 101.393	DIF -R$ 4.659
Indireto	R$ 19.911	R$ 19.387	R$ 523
Torre	R$ 55.250	R$ 57.060	-R$ 1.810
Infra	R$ 12.363	R$ 14.300	-R$ 1.937
Fundação	R$ 6.370	R$ 6.562	-R$ 192
EEE	R$ 104	R$ 193	-R$ 89
ETE	R$ 1.187	R$ 2.205	-R$ 1.018
Contenção	R$ 741	R$ 800	-R$ 59
Terrapplenagem	R$ 809	R$ 886	-R$ 76
CUSTO TOTAL II	R$ 802	R$ 320	R$ 482
Urbanização	R$ 315	R$ 320	-R$ 5
Drenagem	R$ 149	Sem diretriz	R$ 149
Extensão de Rede Eletrica	R$ 84	Sem diretriz	R$ 84
Extensão de Rede Hidráulica	R$ 254	Sem diretriz	R$ 254
CUSTO TOTAL III	R$ 0	R$ 0	R$ 0
Incorridos	R$ 0	R$ 0	R$ 0
CUSTO TOTAL IV	R$ 0	R$ 0	R$ 0
Aprendizado	R$ 0	R$ 0	R$ 0
CUSTO TOTAL V	R$ 0	R$ 1.616	-R$ 1.616
Atualização por INCC	R$ 0	R$ 1.616	-R$ 1.616
CUSTO TOTAL	R$ 97.535	R$ 103.328	-R$ 5.793

INDIRETOS

+616 | G18 – Ensaios (Ensaios de monitoramento de recalque + atualização de Preço)

TORRE

-740 | MO Vertical (Retroalimentação Ago/24 X Out/24)
-707 | Elevador (Utilizado preço conforme alinhamento de Suprimentos)
-357 | Instalações (Atualização de referência de obra + Retroalimentação LVS)
R00: Pq. Boungainville-BA
R01: Vida Botânica-CE

INFRA

-828 | Instalações (Atualização de referência de regional + Atualização simulador)
R00: Regional CE
R01: Regional PE
-279 | Esquadria de Ferro (Ajuste na fundação dos alambrados e gradis)
-777 | Anexos (Atualização composição da piscina conforme novos parâmetros)

ETE/EEE

-1.108 | ETE+EEE (Ajuste para custo nominal da ETE+EEE, anteriormente estava custo por UH)

Operações

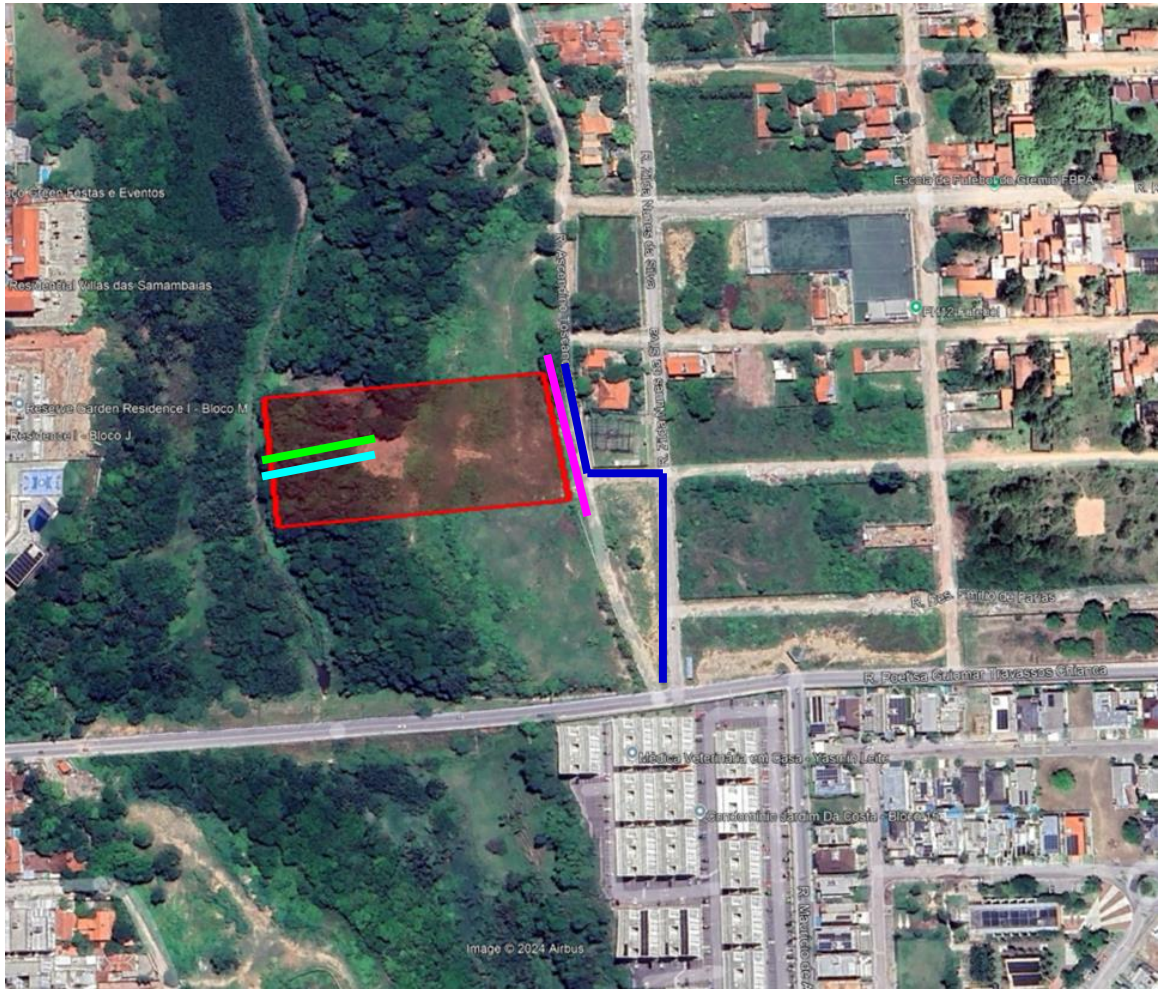

SISTEMA DE ABASTECIMENTO DE ÁGUA
Considerado ligação a aproximadamente 300m, conforme solicitação da regional após terem uma reunião com o diretor comercial da concessionária. Viabilidade ainda não foi disponibilizada.

SISTEMA DE ESGOTAMENTO SANITÁRIO
Considerado ETE dentro do empreendimento conforme solicitação da regional. Viabilidade ainda não foi disponibilizada.

SISTEMA DE DRENAGEM
Descarte em corpo hídrico no final do terreno.

SISTEMA DE ABASTECIMENTO DE GÁS
Abastecimento por GLP.

SISTEMA DE ABASTECIMENTO ELÉTRICO
Não foi emitida a diretriz para confirmar viabilidade técnica para o abastecimento elétrico.

TERRENO

URBANIZAÇÃO
Considerado trecho de pavimentação e passeio na testada do empreendimento.

Operações

Matriz Risco Concessionária	
Água	Nível 5
Esgoto	Nível 5
Drenagem	NA
Elétrica	Nível 3
Gás	NA
Urbanização	NA

LEGENDA		
Nível	Tipo	Status
1	Com Diretriz	Conclusiva
2		Conclusiva com projeto aprovado
3		Conclusiva sem projeto aprovado
4		Não Conclusiva
5	Sem Diretriz	-
NA	-	Não aplicável

Água:
- Não foi emitida a diretriz para confirmar viabilidade técnica para o abastecimento de água.

Esgoto:
- Não foi emitida a diretriz para confirmar viabilidade técnica para o abastecimento de esgoto.

Drenagem:
- Não foi emitida a diretriz para confirmar viabilidade técnica.

Elétrica:
- Viabilidade emitida em 07/2024.

Gás:
- Empreendimento com GLP.

Urbanização:
- Considerado trecho de pavimentação na testada do empreendimento.

Fundação:
- Realizada campanha de sondagem contemplando 10 furos.
- Considerada Estaca Hélice, com diâmetros de 50, 60 e 70cm e profundidade de 14 m.

Logística

PORTAL DO SOL – PB

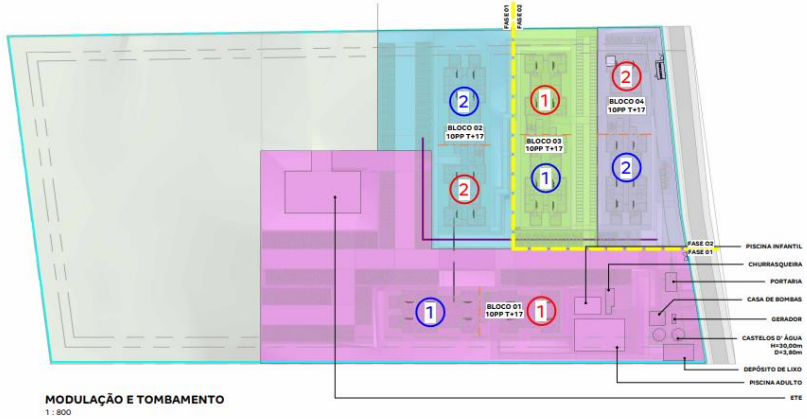

MODULAÇÃO E TOMBAMENTO
1 : 800

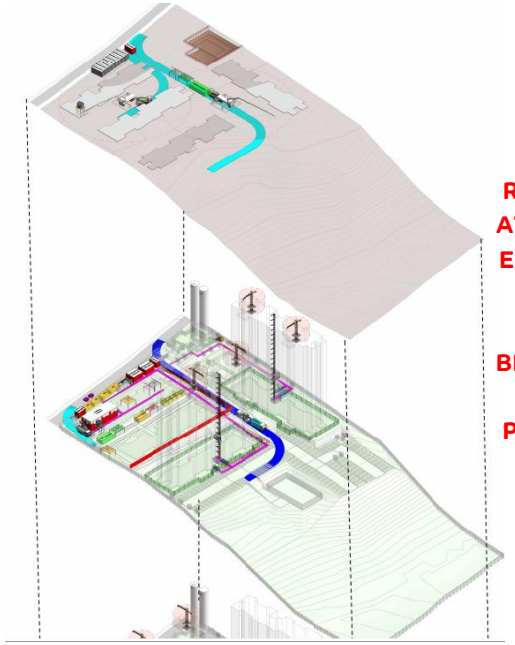

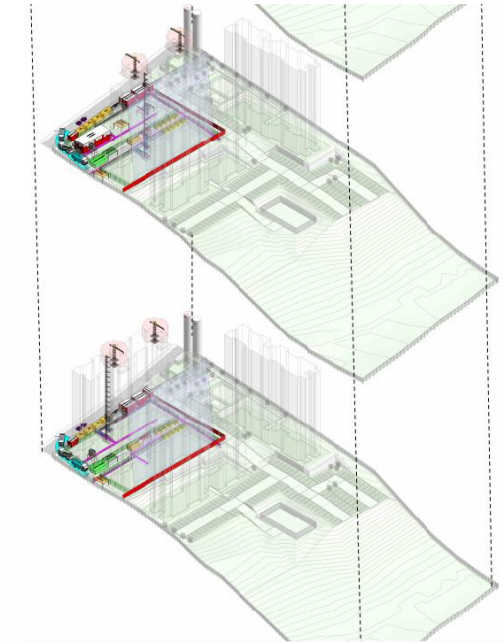

A VIVÊNCIA COM CONTAINERS SERÁ LOCADA SOBRE O RADIER DO BLOCO 04 ATÉ A CONCLUSÃO DA EXECUÇÃO DO BLOCO 03. APÓS A FINALIZAÇÃO DO BLOCO 03, A VIVÊNCIA SERÁ REALOCADA PARA DENTRO DESSE BLOCO.

PRÉ FORMA
1 : 500

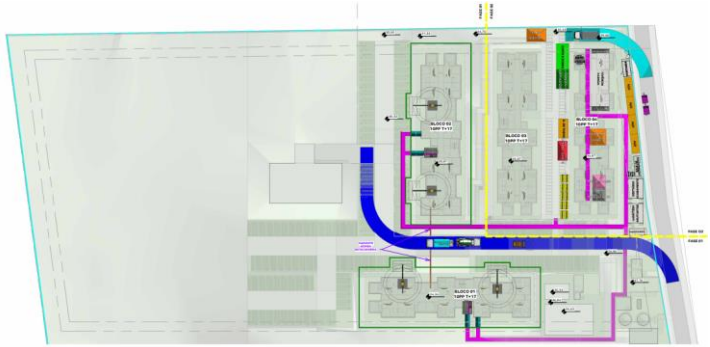

ESTRUTURA E ACABAMENTO-F1
1 : 500

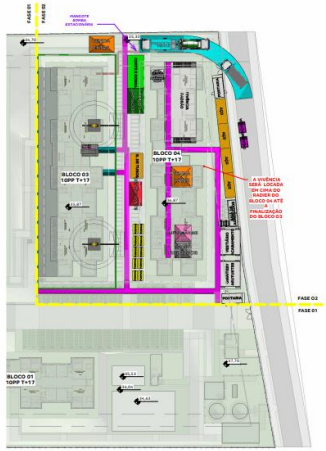

1. ESTRUTURA E ACABAMENTO-F2
1 : 500

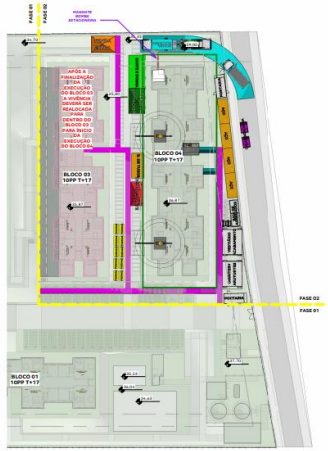

2. ESTRUTURA E ACABAMENTO-F2
1 : 500

Logística

ITENS A SEREM CONSIDERADOS:

➢ **CUSTOS / OBRA**	PREVER CUSTO PARA EQUIPE DE MOVIMENTAÇÃO MANUAL DE MATERIAIS "FORMIGUINHAS" (2 FUNCIONÁRIOS ESTRUTURA E 2 FUNCIONÁRIOS ACABAMENTO), DEVIDO À IMPOSSIBILIDADE DE ACESSO DE MAQUINÁRIOS AO LONGO DA IMPLANTAÇÃO PARA MOVIMENTAÇÃO/DESCARGA DE MATERIAIS. PREVER CUSTO DE ESCADA PROVISÓRIA PARA ACESSAR A COTA DE FUNDO DOS ENTERRADOS E EXECUTAR A ESTRUTURA. PREVER CUSTO PARA PERDA DE CONCRETO DURANTE O PERÍODO DE ESTRUTURA COM UTILIZAÇÃO DE BOMBA ESTACIONÁRIA PARA A CONCRETAGEM CONFORME INDICADO EM PROJETO, NECESSÁRIO DEVIDO À DISTÂNCIA ENTRE PONTO DE PATOLA E BLOCOS E AO GABARITO PREVER CAMADA DE SACRIFÍCIO, PARA QUE O ACESSO DE CAMINHÕES SEJA POSSÍVEL EM PERÍODOS CHUVOSOS, POIS O VIÁRIO EXTERNO NÃO POSSUI ASFALTO (CALÇAMENTO E SOLO NATURAL).
➢ **SSO / OBRA**	CASO O FORNECEDOR DE ELEVADORES SEJA VILLARTA OU OTIS, PREVER ARMAZENAMENTO NO TÉRREO – 1 APARTAMENTO PARA CADA ELEVADOR E GUIA NO CORREDOR OU INFRA. CASO SEJA OUTRO FORNECEDOR (POR EXEMPLO, KONE), PREVER O ARMAZENAMENTO FORA DA TORRE. PARA TIPOLOGIAS F02E E F2EP, INCLUIR UM EXTINTOR A. B. C. (6KG) EM CADA INTERVALO DE CINCO PAVIMENTOS DA TORRE, NÃO ULTRAPASSANDO A DISTÂNCIA MÁXIMA DE 15M NO PLANO VERTICAL.

Pareceres

Análise da Mancha e Implantação

Prospecção

Operações

Inteligência de Mercado

Financeiro

Demanda e Distribuição da Mancha

Potencial de Demanda			Lançados		Lançados + Landbank	
Mancha	CÓD.	Shr.	ANO	MÊS	ANO	MÊS
João Pessoa	JP	40%	900	75	1.080	90

Empreendimento	Renda	Lançamento	mar/26	abr/26	mai/26	jun/26	jul/26	ago/26	set/26	out/26	nov/26	dez/26	jan/27	fev/27	mar/27	abr/27	mai/27	jun/27	jul/27	ago/27	set/27	out/27	nov/27	dez/27
Reserva dos Colibris	3.175	dez-25	26	26	26	26	26	26	26	26	26	26	26	26	26	26	26	22						
Altiplano - F1	**3.204**	**mar-26**		**20**	**20**	**20**	**20**	**20**	**20**	**20**	**20**	**20**	**20**	**20**	**20**	**20**	**20**	**20**	**20**	**20**	**16**			
Altiplano - F2	**3.204**	**set-27**																				**20**	**20**	**20**
Total de Vendas Lançados			**0**	**0**	**0**	**0**	**0**	**0**	**0**	**0**	**0**	**0**	**0**	**0**	**0**	**0**	**0**	**0**	**0**	**0**	**0**	**0**	**0**	**0**
Total de Vendas Lançados + Landbank			**26**	**46**	**46**	**46**	**46**	**46**	**46**	**46**	**46**	**46**	**46**	**46**	**46**	**46**	**46**	**42**	**20**	**20**	**16**	**20**	**20**	**20**

Parecer de I.M sobre a mancha:

O projeto analisado em comitê está em linha com o potencial teórico de demanda calculado para a mancha. (Total Lanç + Landbank)

Canibalização:

Sem Risco de Canibalização

Altiplano – F1 | Mapa Concorrência

		Altiplano – F1	Reserve Altiplano	Jardim Dos Corais
		TENDA	Guedes Pereira	MRV
	Distância Tenda (km)		1,9km	600m
Região 1 Km	População	14.209	11.660	13.909
	Dens. Demográfica	4.552	3.735	4.456
	Renda (R$)	8.107	9.062	5.012
	Classe Social	B1 (8.1k a 16k)	B1 (8.1k a 16k)	B1 (8.1k a 16k)
	PEA Dia	10.387	13.732	6.673
Quantitativo	Lançamento	mar/26	ago/22	fev/22
	Unidades	356	360	408
	Estoque	356	0	20
	VSO	20	13	11
	Stockout	18	0	2
	Preço Nominal (R$)	224.599	252.717	241.370
	Preço CEF (R$)	177.974	202.174	193.096
	Renda Comprador (R$)	3.204	4.400	3.700
	Dif Tenda (R$)		-1.196	-496
	Factibilidade		●	●
Qualitativo	Condomínios	1	1	1
	Torres	4	2	3
	Gabarito	T+17	T+4	T+16
	Plantas (m²)	39m²	53,92m² e 67,12m²	44m² e 42m² e 42m² e 44m²
	Tipologia	2 Dorms	2 Dorms	2 Dorms
	Opções	Não	Não	Garden
	Varanda	Sim	Sim	Não
	Suite	Não	Sim	Não
	Dif. Entrega	Não	Piso Porcelanato	Piso Laminado
	Vagas	20% de Vagas	100% de Vagas	100% de Vagas
	Lazer	Piscina Infantil, Piscina Adulta, Espaço Office, Fitness Externo, Playground Kids, Playground Baby.	Tem Sacada, Tem Suítes, Bicicletário, Churrasqueira a Carvão, Espaço Gourmet, Fitness Center, Pet Place, Piscina, Piscina infantil, Playground, Quadra Poliesportiva, Redário, Sacada, Salão de Jogos,	Tem Garden, Bicicletário, Brinquedoteca, Coworking, Coworking, Espaço Gourmet, Pet Place, Piscina, Salão de Festas, Salão de Jogos,

Farol Renda
● Acima de 300
● Entre 0 e 300
● Abaixo de 0

Diagnóstico Concorrência

- Os concorrentes mapeados vendem seus projetos em um target de preço e renda superior ao estimado para o Altiplano.

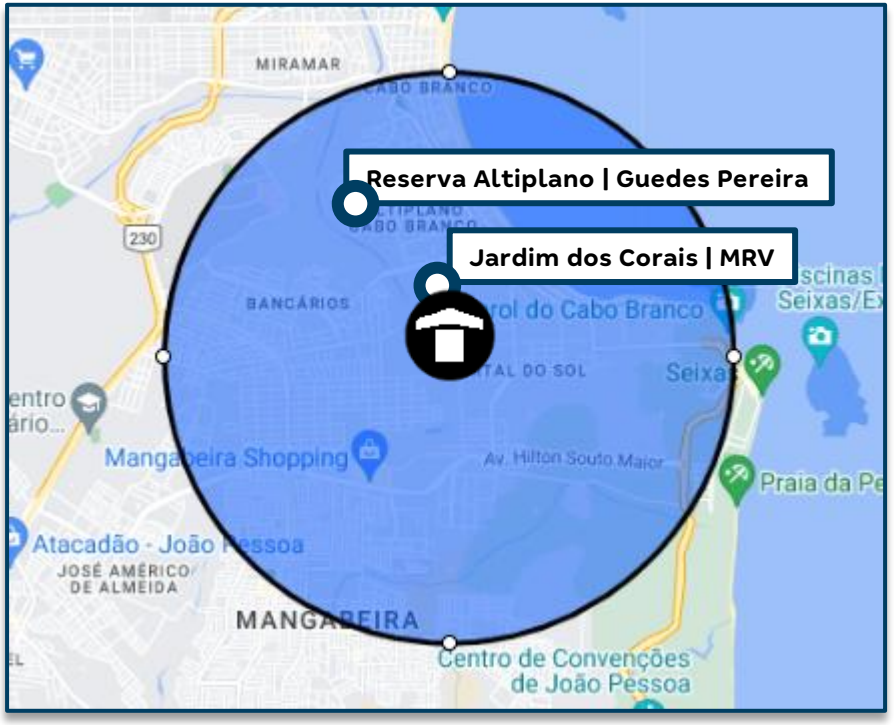

Simulação de Preço

Informações Viabilidade

Projeto:	Altiplano - F1			
Tipo:	**Sem Varanda**		**Sem Varanda**	
Método	**Ref. Vista do Golf (PE)**		**Vision**	
Avaliação	235.000		235.000	
Renda Inicial (VF)	2.717		2.896	
Renda Final*	-		-	
% RET1	-		50%	
Tipo:	**VF**	**R$**	**VF**	**R$**
Ato	2,07	5.624	0,54	1.562
FGTS	1,45	3.943	0,54	1.555
Financiamento	93,65%	149.069	95,83%	157.351
Subsídio	146,52%	17.470	147,51%	12.604
Prazo de Pró-soluto	22	22	22	22
Pró-Soluto	102,51%	22.264	88,07%	20.388
Preço Raso (RS)	198.369	198.369	193.460	193.460
TCD	83,02%	22.738	78,36%	22.874
VSO	11	11	11	11
Preço de Venda	**221.107**	**221.107**	**216.334**	**216.334**
Elasticidade	0,000%	0,000%	0,000%	0,000%
Preço de Venda Final	**221.107**	**221.107**	**216.334**	**216.334**
Preço Raso (R$)	**198.369**		**193.460**	
% de Raso	**89,72%**		**89,43%**	
BP25 - Não Inflacionado	**-**		**-**	
BP25 - Inflacionado	**-**		**-**	

Simulação de Preço

Informações Viabilidade

Projeto:	Altiplano - F1			
Tipo:	**Com Varanda**		**Com Varanda**	
Método	**Ref. Vista do Golf (PE)**		**Vision**	
Avaliação	245.000		245.000	
Renda Inicial (VF)	3.747		3.540	
Renda Final*	-		-	
% RET1	-		25%	
Tipo:	**VF**	**R$**	**VF**	**R$**
Ato	0,87	3.246	0,53	1.877
FGTS	0,99	3.702	0,65	2.297
Financiamento	100,74%	189.091	96,32%	176.094
Subsídio	58,66%	1.052	303,66%	6.654
Prazo de Pró-soluto	22	22	22	22
Pró-Soluto	79,11%	23.694	82,57%	23.364
Preço Raso (RS)	220.785	220.785	210.286	210.286
TCD	63,20%	23.872	65,45%	23.356
VSO	9	9	9	9
Preço de Venda	**244.657**	**244.657**	**233.642**	**233.642**
Elasticidade	0,000%	0,000%	0,000%	0,000%
Preço de Venda Final	**244.657**	**244.657**	**233.642**	**233.642**
Preço Raso (R$)	**220.785**		**210.286**	
% de Raso	**90,24%**		**90,00%**	
BP25 - Não Inflacionado	**-**		**-**	
BP25 - Inflacionado	**-**		**-**	

Análise de Preço

Informações Viabilidade

Projeto:	Altiplano - F1	
Tipo:	**Faixa 2**	
Método	**Vision**	
Avaliação	239.775	
Renda Inicial (VF)	3.204	
Renda Final*	-	
Tipo:	**VF**	**R$**
Ato	0,54	1.712
FGTS	0,59	1.909
Financiamento	96,07%	166.301
Subsídio	222,07%	9.763
Prazo de Pró-soluto	22	22
Pró-Soluto	85,44%	21.809
Preço Raso (RS)	201.495	201.495
TCD	72,20%	23.104
VSO	20	20
Preço de Venda	**224.599**	**224.599**
Elasticidade	0,000%	0,000%
Preço de Venda Final	**224.599**	**224.599**
Preço Raso (R$)	**201.495**	
% de Raso	**89,71%**	
Raso Todas as Fases	**200.999**	
Nominal Todas as Fases	**224.104**	

1

Análise de Riscos	Farol IM
IM avalia o Preço Vision como **factível**.	

1) I.M está de acordo com o preço Vision, tendo em vista que, o projeto está em uma região com bons indicadores sociodemográficos, como renda e PEA/Dia, o mesmo também se encontra próximo de pontos de interesses como supermercados e a Praia de Cabo Branco.

Além disso, conforme consta no slide "Panorama de Concorrência", os concorrentes da região vendem em um target de preço e renda acima do previsto para o produto Tenda.

Resumo de Preços

Vision

Nome Fase	Tipologia	Renda	Ato	FGTS	Cond.	Subsídio	PSOL	TCD	VSO	Nom. Pré	Avali.	Elast.	Nom. Pós	Raso Pós	PSOL (m)	RET1
Altiplano - F2	Sem Varanda	2.896	0,54	0,54	95,9%	147,5%	88,1%	78,4%	11	215.407	235.000	0,0000%	215.407	192.533	21	50%
Altiplano - F2	Com Varanda	3.540	0,53	0,65	96,5%	303,7%	82,6%	65,5%	9	232.580	245.000	0,0000%	232.580	209.224	21	25%

Percepção Comercial

Entorno

Características do Bairro: Portal do Sol

- Bairro nobre da zona Leste da capital paraibana;
- Região com a maior concentração de investimentos imobiliários e condomínios horizontais de alto padrão.

Mobilidade e pontos comerciais

- Praia de Cabo Branco – 1,4km
- 6 linhas de ônibus servem o bairro
- Mercearias
- Farmácias
- Escolas

Altiplano Sunset

Parecer: Ciclo está de acordo com o preço e VSO citados, visto que, trata-se de uma área sem concorrência com stk atual, em uma região conhecida pelos investimentos imobiliários e aspiracional para o nosso público, por ser uma área de alto padrão. Apesar de serem produtos mais completos, os concorrentes que finalizaram stk recente tinham preço mais elevado. Além disso, nosso produto já contempla varanda e piscina.

Pareceres

Análise da Mancha e Implantação

Prospecção

Operações

Inteligência de Mercado

Financeiro

Informações Gerais – Consolidado

Altiplano Sunset – PB – João Pessoa Capital

Datas e Prazos

	Compra	Lançamento	Início Obra	Término Obra	LÇTO até IO	IO até TO	Chaves	LÇTO até Chaves
Consolidado	jun-24							
Altiplano F1 com varanda		fev-26	ago-26	jan-28	6 meses	17 meses	fev-29	36 meses
Altiplano F1 sem varanda		fev-26	ago-26	jan-28	6 meses	17 meses	fev-29	36 meses
Altiplano F2 com varanda		set-27	mar-28	jul-29	6 meses	16 meses	set-30	36 meses
Altiplano F2 sem varanda		set-27	mar-28	jul-29	6 meses	16 meses	set-30	36 meses

Terreno e Incorridos

TOTAL (R$ + Perm.):	14,84 MM	Incorrido Terreno: 0,00 MM	Área do Terreno (100%):	19.342 m²	Área Líquida do Terreno: 14.335 m²
Cash:	0,00 MM		Custo de terreno m²:	767,2	Custo de terreno m² Área Líquida: 1.035,2
Permuta Financeira:	14,84 MM (9,30%)		VaR 25 (R$ mil):	0	Fração Terreno/Terreno + Custo Obra (%VGV): 9,3% / 52,8%
Permuta Física:	0,00 MM (0,00%)		VaR 26 (R$ mil):	0	CA Máx/Proj. 4,0 / 2,5
Ato / %VGV:	0,00 MM / 0,0%		Incorrido de Construção:	0,00 MM	Incorridos de Incorporação: 0,00 MM

Vendas

Fases	Nº Pavimentos	Preço Raso Unit.	Qtde	Preço Unit.	Aval. CEF	Cond. Parcela	% Pró-soluto	% TCD
Altiplano F1 com varanda	T+17	210.357	170	233.642	245.000	96,3%	82,6%	65,5%
Altiplano F1 sem varanda	T+17	193.462	186	216.334	235.000	95,8%	88,1%	78,4%
Altiplano F2 com varanda	T+17	209.296	170	232.580	245.000	96,5%	82,6%	65,5%
Altiplano F2 sem varanda	T+17	192.535	186	215.407	235.000	95,9%	88,1%	78,4%

Unidades Totais:	712	Preço Médio:	224.103	Renda Média:	3.204	ITBI+Emol. Unit.:	4.450
Unidades Tenda:	712	Avaliação Média:	239.775	Ato:	1.727 (0,54 Salários)	Custo do Ciclo Unit.:	13.964
VSO:	20 Unit.s.	VGV Total:	159.561.600	FGTS:	1.908 (0,6 Salários)	Preço Raso Médio:	201.035
RET Médio:	2,9%	VGV Tenda:	159.561.600	% em RET 1%:	38%		

Construção

Custo Total Unit.:	97.536	Eventuais:	4,00%	Área priv (m²):	39,03	Gape / Mês Unit.:	11,08

Resultado

LI (R$):	19.168.632	LI:	19,97%	Exposição de Caixa (R$):	11.267.258	Margem Bruta Econômica:	38,46%
TIR:	111,10%	LI Aprovação:	20,00%	Ger. Caixa 12 meses (R$):	(1.983.318)	Margem Bruta REF:	41,78%
Exposição de Caixa:	6,45%	Δ LI:	-0,03%	Ger. Caixa 24 meses (R$):	(10.622.442)	Margem Rasa Econômica:	30,62%
Payback Contingente (21 m):	19 m/ (-2 m)	LI Resiliência:	14,24%	Ger. Caixa Marginal (R$):	44.772.262	Margem Rasa REF:	35,11%
Payback Consolidado:	19 meses					Margem de Contribuição Econômica:	27,34%

DRE

R$ Mil - Valores Nominais - Compra	Altiplano Sunset		Primeira Fase		Demais Fases	
	Nominal	%	Nominal	%	Nominal	%
Receita	174.759	100,0%	84.224	100,0%	90.535	100,0%
PIS/COFINS	(2.750)	1,6%	(1.325)	1,6%	(1.425)	1,6%
Custo Total	(105.862)	61,5%	(54.980)	66,3%	(50.882)	57,1%
Custo Terreno	(16.771)	9,8%	(8.224)	9,9%	(8.547)	9,6%
Custo Relacionados a Terreno	(723)	0,4%	(360)	0,4%	(363)	0,4%
Custos de Incorporação	(3.391)	2,0%	(1.609)	1,9%	(1.782)	2,0%
Custo de Construção	(84.977)	49,4%	(44.787)	54,0%	(40.190)	45,1%
Lucro Bruto Econômico	66.147	38,5%	27.919	33,7%	38.228	42,9%
Custo para Rateio	-	0,0%	-	0,0%	-	0,0%
Lucro Bruto Contábil	66.147	38,5%	27.919	33,7%	38.228	42,9%
Despesas de Selling	(15.105)	8,8%	(7.274)	8,8%	(7.831)	8,8%
Contingência	(4.019)	2,3%	(1.937)	2,3%	(2.082)	2,3%
Margem de Contribuição	**47.022**	**27,3%**	**18.708**	**22,6%**	**28.314**	**31,8%**
IR e CSLL	(2.250)	1,3%	(1.084)	1,3%	(1.166)	1,3%
Margem Líquida	**44.772**	**26,0%**	**17.624**	**21,3%**	**27.149**	**30,5%**

R$ Mil - VPL - Compra	Altiplano Sunset		Primeira Fase		Demais Fases	
	VP	%	VP	%	VP	%
Receitas	95.999	100,0%	52.710	100,0%	43.289	100,0%
PIS/COFINS	(1.488)	1,5%	(817)	1,5%	(671)	1,5%
Custos e Despesas Totais	(75.343)	78,5%	(43.481)	82,5%	(31.862)	73,6%
Custo Terreno	(8.737)	9,1%	(4.811)	9,1%	(3.926)	9,1%
Custo Relacionados a Terreno	(617)	0,6%	(307)	0,6%	(310)	0,7%
Custos de Incorporação	(2.430)	2,5%	(1.276)	2,4%	(1.154)	2,7%
Custo de Construção	(51.483)	53,6%	(30.445)	57,8%	(21.038)	48,6%
Despesas de Selling	(9.660)	10,1%	(5.317)	10,1%	(4.342)	10,0%
Contingência	(1.200)	1,2%	(657)	1,2%	(543)	1,3%
IR e CSLL	(1.217)	1,3%	(668)	1,3%	(549)	1,3%
Lucro Imobiliário	**19.169**	**20,0%**	**8.412**	**16,0%**	**10.756**	**24,8%**

Comparativo

Comparativo dos Estudos - Consolidado	Anterior	Atual	Atual vs Anterior	Δ%
Data Estudo:	fevereiro-25	fevereiro-25	0 Meses	N/A
Lançamento:	fevereiro-26	fevereiro-26	0 Meses	N/A
Uhs:	712	712	-	0,0%
Preço Nominal:	224.103	224.103	-	0,0%
Preço Raso:	201.035	201.035	-	0,0%
Preço Nominal Inflacionado:	253.275	253.275	-	0,0%
Preço Raso Inflacionado:	227.230	227.230	-	0,0%
Renda Média:	3.204	3.204	-	0,0%
RET Médio:	0	2,9%	0,0 p.p.	
% em RET 1%:	0	38,1%	0,0 p.p.	
Ato:	0,5	0,5	-	0,0%
FGTS:	0,6	0,6	0,0	0,0%
VSO:	20	20	-	0,0%
VSO2:	20	20	-	0,0%
ITBI/Emol. (Unit):	4.450	4.450	-	0,0%
Avaliação:	239.775	239.775	-	0,0%
Cond. Financiamento:	96,1%	96,1%	0,0 p.p.	0,0%
Subsídio Utilizado:	222,1%	222,1%	0,0 p.p.	0,0%
Percentual Pró-Soluto:	85,4%	85,4%	0,0 p.p.	0,0%
Percentual utilização TCD:	72,2%	72,2%	0,0 p.p.	0,0%
Prazo construção F1:	17	17	-	0,0%
Prazo de Pró-Soluto F1:	22	22	-	0,0%
Custo Total Inf (uh):	148.163	148.682	519	0,4%
Custo Construção:	97.536	97.536	-	0,0%
Custo Construção Corrigido:	97.536	97.536	-	0,0%
Fração de construção:	44%	43,5%	0,0 p.p.	0,0%
INCC Folha Rosto:	1.159,54	1.159,54	-	0,0%
Custo Terreno:	16.252.612	16.770.885	518.273	3,2%
Custo Relacionados a Terreno (uh):	1.224	1.015	(208)	-17,0%
Fração do Terreno[1]:	9,3% / 52,8%	9,3% / 52,8%	0,0 p.p.	0,0%
Custo de Incorp. por uh:	4.763	4.763	-	0,0%
ITBI/Emol. (Total):	3.168.054	3.168.054	-	0,0%
Custo do Ciclo:	13.964	13.964	-	0,0%
LI Resiliência:	14,2%	14,2%	0,0 p.p.	0,0%
Lucro Imobiliário:	20,0%	20,0%	-0,1 p.p.	-0,3%
LI Resiliência:	14,2%	14,2%	0,0 p.p.	0,0%
Exposição de caixa:	6,5%	6,4%	-0,1 p.p.	-1,3%
TIR:	108,3%	111,1%	2,8 p.p.	2,6%
Margem Bruta REF:	42,0%	41,8%	-0,2 p.p.	
Margem Bruta Econômica:	38,7%	38,5%	-0,2 p.p.	-0,6%
Margem Rasa REF:	35,3%	35,1%	-0,2 p.p.	
Margem Rasa Econômica:	30,9%	30,6%	-0,2 p.p.	-0,8%
Margem Contribuição Econômica:	27,6%	27,3%	-0,2 p.p.	-0,8%
Payback Contingente (Régua 21 m):	19 m/ (-2 m)	19 m/ (-2 m)	0	0,0%
Payback Consolidado:	19 Meses	19 Meses	0 Meses	0,0%

[1] Valor do terreno contratual

Obrigado