Tenda

sua próxima conquista

Book de Reversão Sem Reneg

Regional: SP – Zona Oeste

Projeto: Essence Butantã (Eiras Garcia)

Data Comitê: 02/04/2025

Atualização Material

Comparativo dos Estudos - Consolidado	Anterior	Atual	Atual vs Anterior	Δ%
Data Estudo:	março-25	março-25	0 Meses	N/A
Lançamento:	agosto-26	outubro-26	2 Meses	N/A
Preço Nominal Inflacionado:	280.160	282.448	2.287	0,8%
Preço Raso Inflacionado:	262.220	264.361	2.141	0,8%
Custo Total Inf (uh):	158.914	160.135	1.221	0,8%
Custo Terreno:	8.947.818	8.999.647	51.829	0,6%
Lucro Imobiliário:	20,0%	20,0%	0,0 p.p.	0,2%
LI Marginal:	20,1%	20,1%	0,0 p.p.	0,2%
Exposição de caixa:	12,4%	12,4%	0,0 p.p.	-0,2%
TIR:	91,4%	91,5%	0,0 p.p.	0,1%
Margem Bruta REF:	43,7%	43,7%	0,0 p.p.	
Margem Bruta Econômica:	39,9%	39,9%	0,0 p.p.	0,1%
Margem Rasa REF:	39,8%	39,8%	0,0 p.p.	
Margem Rasa Econômica:	35,2%	35,2%	0,0 p.p.	0,1%
Margem Contribuição Econômica:	28,3%	28,3%	0,0 p.p.	0,1%
Payback Contingente (Régua 21 m):	20 m/ (-1 m)	20 m/ (-1 m)	0	0,0%
Payback Consolidado:	20 Meses	20 Meses	0 Meses	0,0%

Postergação do lançamento de ago/26 para out/26.
Em razão da nova tipologia T+25 com varanda na esteira de licenciamento.

One Page – Essence Butantã c/ Cash Collateral

Cidade	São Paulo	**Mancha de demanda**	SP - SZN1 - São Paulo Norte 1
Regional	SP	**Cluster MPR**	4 - Azul
Cenário de Aprovação	Aprovação	**Tipo de Aprovação**	Consolidado
Fase Anterior	N/A		
Tipo de Comitê	Reversão s/ Reneg	**Versão da VF**	Versão 1.0: Mar

Unidades (% Vagas)	409 (0%)	**CA Máx | Proj**	4,0 | 5,3
Tipologia	F2E - Concreto	**Escritura**	set-26
Fases	1 fases	**Lçto | Duração (m)**	out/26 | 28

Valor Líquido do Terreno (% VGV)	8.976 (8,4%)	**Un. Perm. Fís (% Ter)**	0 (0,0%)
Cash (Correção)	2.600 (Não)	**%VGV Perm Fin Líquida (% Ter)**	6,2% (73,6%)
Valor R$/m²	4.380	**VAR (%VGV)**	000 (0,0%)

Custo Construção (%VGV)	43.662 (42,2%)	**Indireto Unit.**	24.430
Prazo da Obra (meses)	22	**Torre Unit.**	63.154
Custo Total Unit. (LPU):	106.753 (88)	**Infra Unit.**	11.551
Início de Obra	abr-27	**Fundação Unit.**	5.694

Preço Nominal Unit.	253.073	**VSO**	23
Preço Raso Unit.	236.834	**Referência**	VISION
Avaliação Unit.	297.115	**Renda (% em RET 1%)**	4.224 (0,0%)

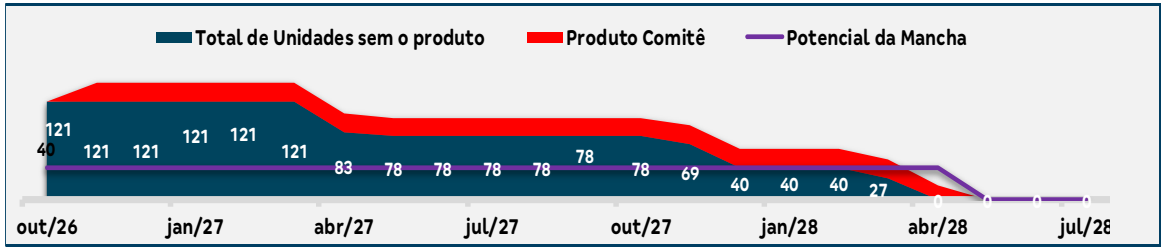

LI (Régua):	**20,0% (20,0%)**	**Margem Bruta Econômica:**	39,9%
LI Marginal:	20,1%	**Margem Rasa Econômica:**	35,2%
Margem Bruta REF:	43,7%	**Margem Contribuição Econômica:**	28,3%
Margem Rasa REF:	**39,8%**	**Exposição (% VGV):**	13.823 (12,4%)
TIR:	91,5%	**VGV Total:**	103.507
Payback Contingente (21 m) :	**20 m/ (-1 m)**	**Ger. Caixa 12 meses (R$):**	-
Payback Consolidado:	20	**Ger. Caixa 24 meses (R$):**	(8.615)

Destaques

[1] Localização: O Terreno está localizado na Av. Eng. Heitor Antônio Eiras Garcia, 1469 – Butantã, mancha ZO2 - Zona Oeste de São Paulo. Localização estratégica entre as Av. Politécnica, Av. Corifeu de Azevedo Marques, Shopping Butantã e Rodovia Raposo Tavares. Região privilegiada cercada por comércios e serviços. Terreno em Zeis, pequeno com 2.522,22 m².

[2] Projeto: é composto por 1 condomínio com 409 unidades, sem vagas, fase única, sendo 175 unidades com varanda, tipologia F2E CT T+25, 1 torre 16pp em L. CA do projeto está em 5,29x. Número de unidades definidas com varanda foi escolha em função da obrigação de destinação de parte das unidades para HIS (renda até 3 SM), deste modo varandas serão destinadas exclusivamente para unidades HIS2 (renda até 6 SM) e R2V (renda livre). Número máximo de unidades possíveis para enquadramento em HIS2 ou R2V é de até 222 UH. A escolha por 175 varandas foi uma restrição técnica (possível *upside* futuro).

[3] Condição Comercial: R$ 8.600.000,00 (valor contratual e definido em alvará judicial), sendo (i) R$ 2.600.000,00 pagos em dinheiro contra a lavratura da escritura (60% pagos via depósito judicial para um herdeiro interdito) e (ii) R$ 6.000.000,00 pagos em permuta financeira, na fração de 7% da receita líquida. Para aferição da receita líquida serão descontados 12% do VGV. Mais detalhes slide 12; Garantia: Carta Fiança com prazo de vigência anual para garantia de R$ 6.000.000,00 (em VF está sendo considerado *cash colateral*);

[4] Condições Resolutivas: Etapa I: Prazo 120 dias para resolutivas técnicas e jurídicas; Etapa II: Em até 18 meses após a superação da Etapa I para aprovação de projeto, contratação CEF, análise técnica, financeira e comercial para o lançamento do empreendimento;

[5] Contaminação: laudo ambiental apontou contaminação de solo. A solução envolverá remoção, descarte e troca da camada superficial. Houve redução do custo estimado para a remediação (R$ 1,3MM para R$ 585k). Em CVC há previsão de desconto de até R$ 860k do preço do terreno.

[6] Reversão: Projeto entregando rentabilidade dentro da régua de 20% de LI e Margem bruta ~40%. Para atingir este resultado trabalhamos em 3 frentes, (i) melhorias de projeto através do adensamento (torre atual 16pp *versus* torre 14pp comitê dez/24) e inclusão de mix de varandas, (ii) redução do custo de remediação (VF dez/24 previa valor adicional pago pela Tenda para a remediação, agora 100% do custo com remediação será custeado pelo vendedor do terreno) e (iii) tentativa falha de reneg com os vendedores para substituir a carta fiança por seguro garantia e aumento do preço (condição inicial antes de cedermos à carta fiança era R$ 9,0MM *versus* R$ 8,6MM atual). A retirada da carta fiança foi negada pelos vendedores sob pena de distrato. Em dez/24 baixamos 178 UH, agora pleiteamos a baixa das 231 UH restantes.

[7] Cenário sem *cash colateral*: projeto entrega LI=21,1%

Pareceres

Análise da Mancha e Implantação

Prospecção

Operações

Inteligência de Mercado

Financeiro

Anexos

Pareceres

Área	Riscos Associados	Parecer	Flag
Jurídico Aquisição	OK, sem ressalvas.	Ok	
Pré- legalização	OK, sem ressalvas.	Ok	
DPP	N/A	Ok	
GETEC	Diretriz da Sabesp está para 358 UH. O cenário atual possui 409 UH.	Ok com ressalvas	
Logística	Sem riscos associados	Ok	
Prospecção	Oportunidade de negócio em localização privilegiada na ZO. Projeto foi melhorado através do adensamento (CA 5,29x) e de inclusão de mix de varandas. A diretriz para abastecimento de água/esgoto para 409 UH foi solicitada mas ainda não recebemos da Sabesp, diretirz atual com 358 UH emitida com água e esgoto na porta. Realizamos diversas tentativas falhas de reneg para retirada da carta de fiança sob pena de distrato.	Ok	
Inteligência de Mercado	IM Avalia o Preço Vision como factível	Ok	
Comercial/Ciclo	Ok	Ok	
Estudos Econômicos	Ok	Ok	

Pareceres

Análise da Mancha e Implantação

Prospecção

Operações

Inteligência de Mercado

Financeiro

Anexos

Localização – Av. Eng. Heitor Antônio Eiras Garcia, 1469 – Butantã – São Paulo - SP

USP

HOSPITAL

ESCOLA MUNICIPAL

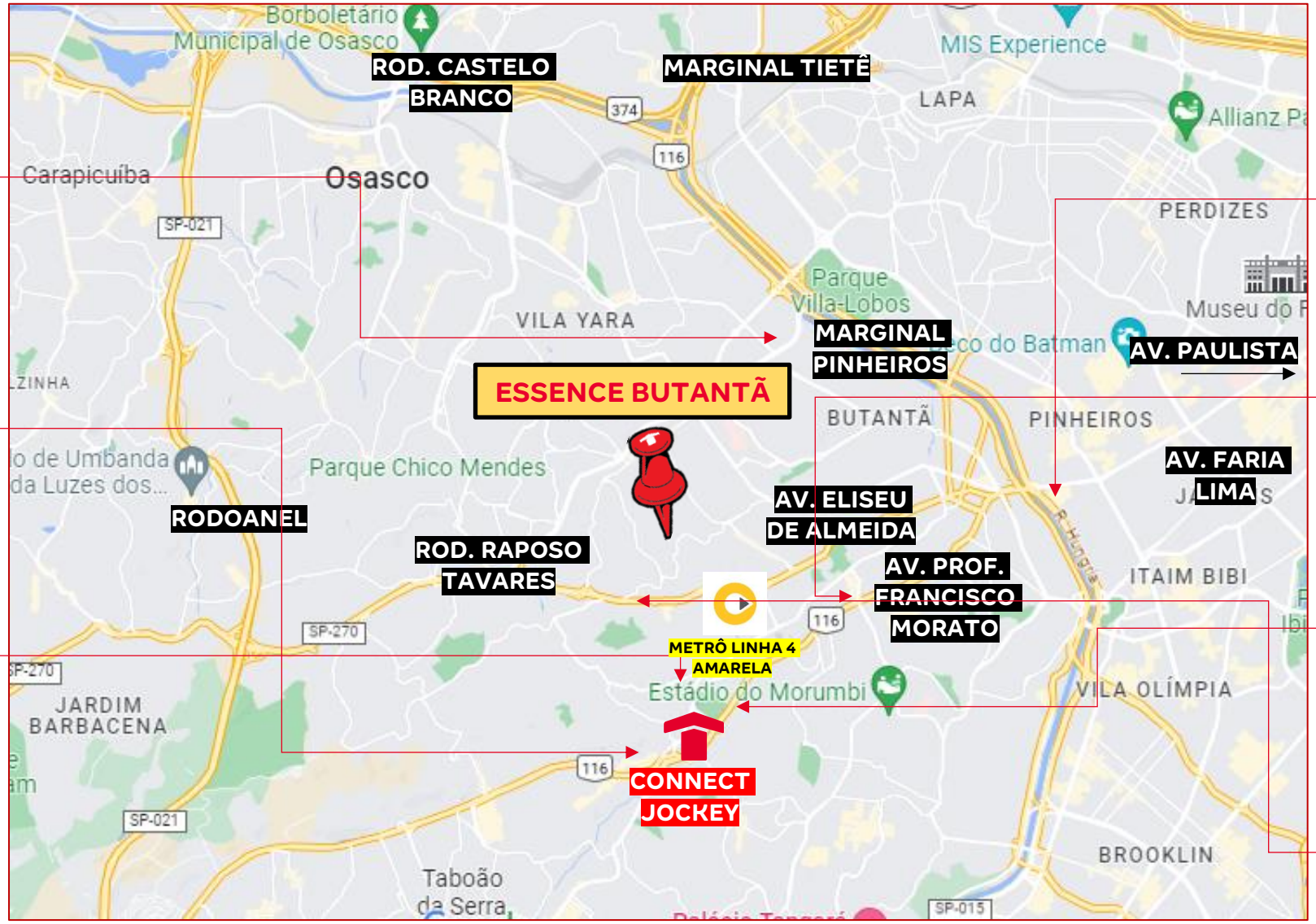

SHOPPING ELDORADO

SHOPPING BUTANTA

PARQUE CHACARA JOCKEY

SHOPPING RAPOSO

Localização – Av. Eng. Heitor Antônio Eiras Garcia, 1469 – Butantã – São Paulo - SP

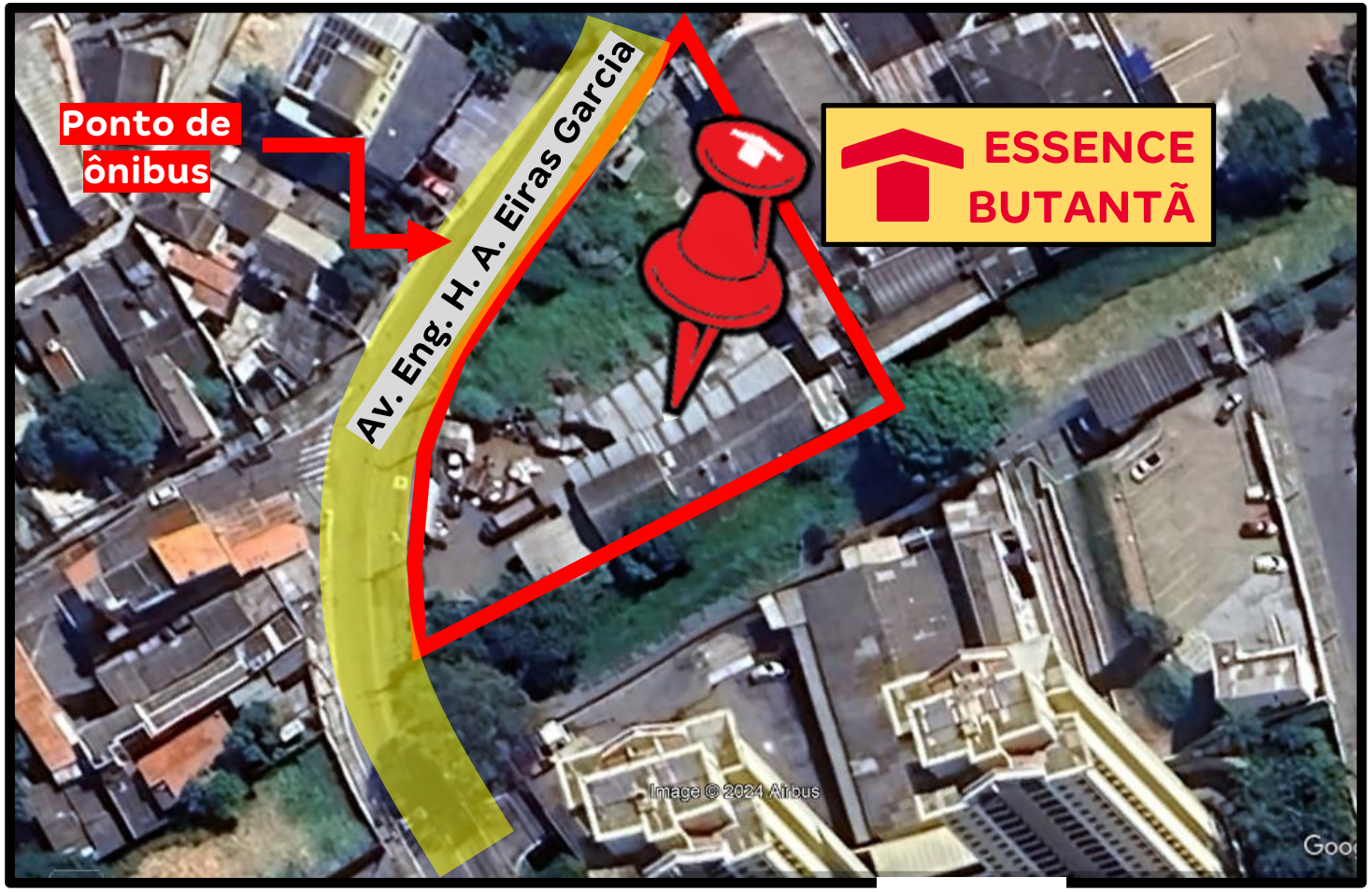

Mancha de Demanda

MANCHAS DE DEMANDA
• SZO– São Paulo Oeste

LandBank

1. Vilaggio Butantã
2. Connect Jockey
3. Life Jaguaré
4. Villa Butantã
5. Eiras Garcia

Cluster MPR – (Comitê)
● Cluster 4 - Azul

Região
Capital

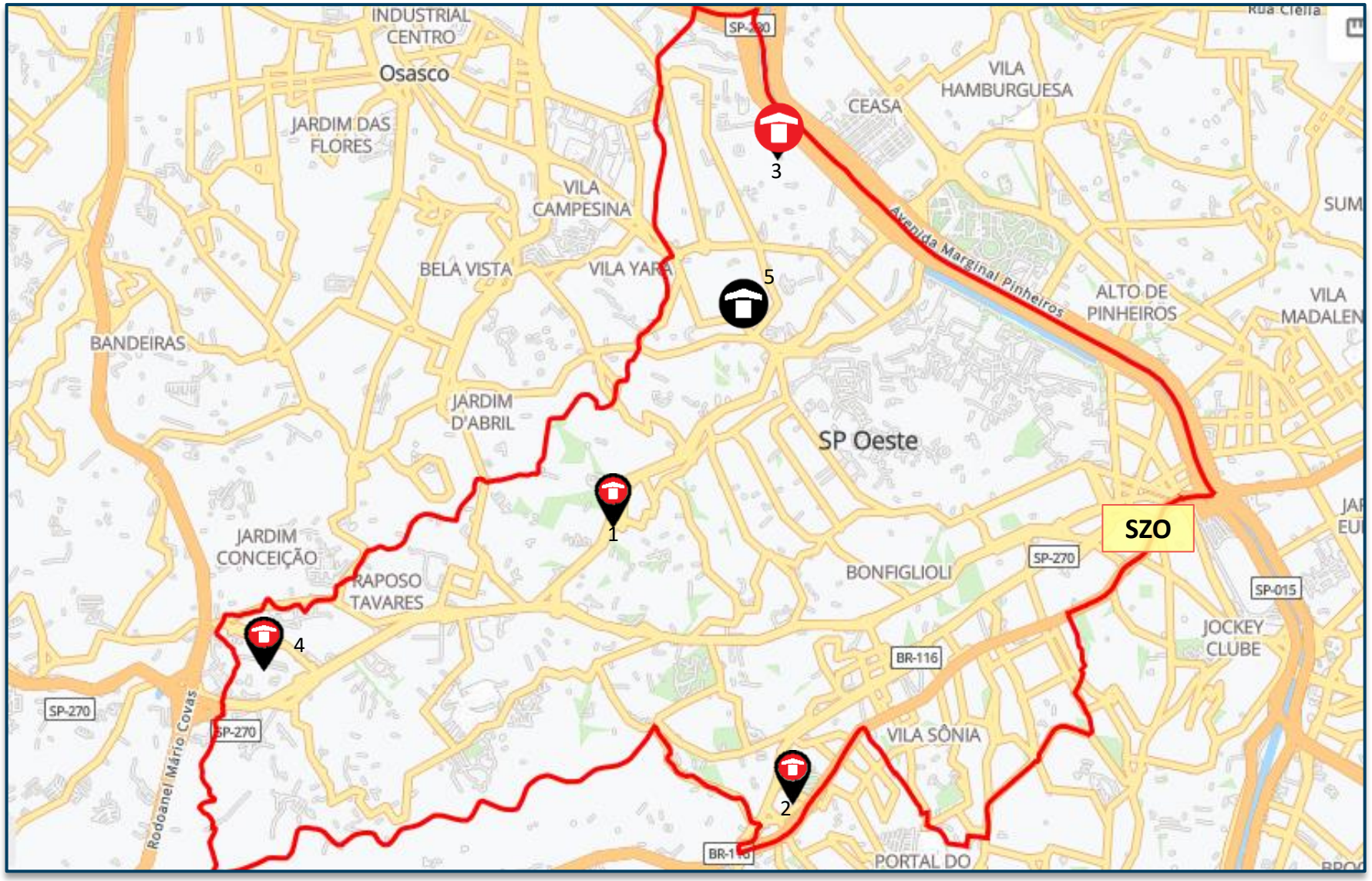

Lançados LandBank Comitê

PRODUTO

Empreendimento Eiras Garcia
Investimento

Informações Gerais – Condomínio Único		
Terreno	**Área matrícula escriturada**	2.430,00m²
	Área poligonal retificadora	2.522,25m²
	App/fna	Não/Não
	Reserva de calçada/ melhoramento víario	Sim
	Área liquida	2.248,02m²
	Zoneamento	Zeis-03
	Ca máximo	4,00
	Ca projetado	5,29
	Incentivo HIS projetado	1,29
	Gabarito máximo	NA
Geral	**Total uh**	409 (309 uh + 100 uh incentivo)
	Total de vagas	01 PCD 1 C/D
Tipologia	**Tipologia**	SP-0200-LN-CD15-LE2B-16P3
	Gabarito	T+25
	Lâmina	16PP
	Área privativa	32,44m² e 32,80m²
Condomínio	**Unidade pcd**	13 (cobertura)
	Unidade lazer|técnica	06 | 01
	Torres	01
	Fase	01
Lazer	**Lazer coberto**	Salão de festas Gourmet, Churrasqueira, Brinquedoteca, Espaço Teen, Espaço Office, Espaço saúde e Fitness
	Lazer descoberto	Play Kids, Play Baby, Fitness externo e Quadra gramada.

PRODUTO

Empreendimento Eiras Garcia
Investimento

	Descrição	Criticidade	Parecer
Usabilidade	**Limite supercondomínio**		
	Acesso		
	Percurso do pedestre até torre		
Diferencial produto	**Atributos Infra**	Sim	Quadra gramada.
	Atributos Torre	Sim	Varanda em face interna (175 UH)
	Edifício Garagem	Não	



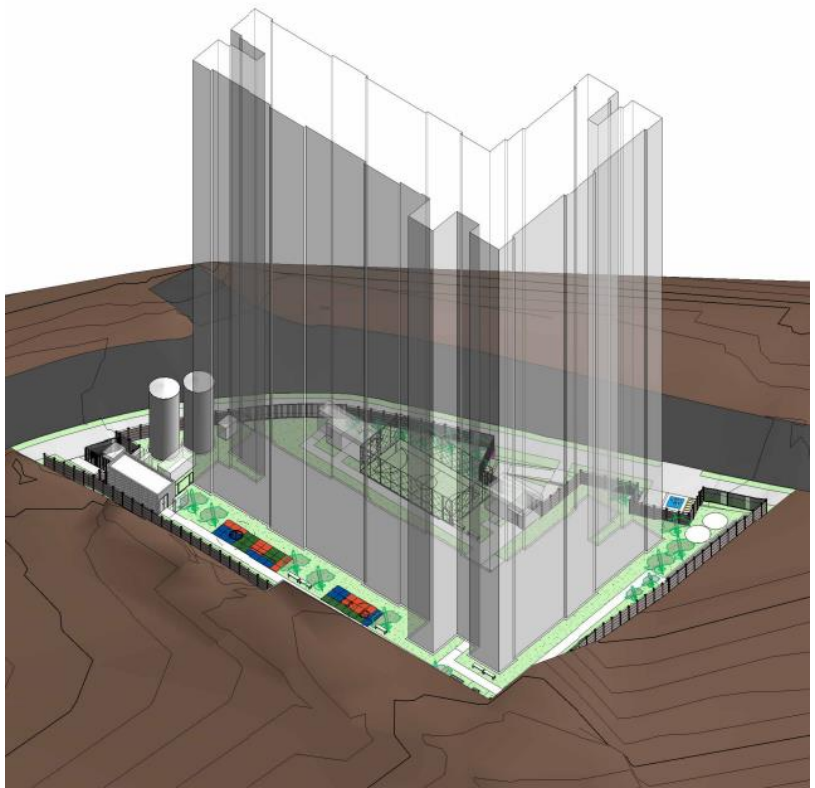

Pareceres

Análise da Mancha e Implantação

Prospecção

Operações

Inteligência de Mercado

Financeiro

Anexos

Condições do Negócio

➢ VALOR DO NEGÓCIO

- R$ 8.600.000,00 (valor contratual)

➢ CONDIÇÃO COMERCIAL

- 30% em dinheiro
- 70% em permuta financeira (7% sobre a receita líquida – desconto de 12% do VGV)

➢ FORMA DE PAGAMENTO

- R$ 2.600.000,00 pagos em dinheiro contra a lavratura da escritura (parte do pagamento está condicionado ao alvará judicial, um dos vendedores é interditado); (previsão set/26)
- R$ 6.000.000,00 pagos em permuta financeira, na fração de 7% da receita líquida. Para aferição da receita líquida serão descontados 12% do VGV;
  - O valor de R$ 6.000.000,00 é Preço Mínimo Garantido (PMG) sem reajuste com prazo para pagamento em 36 meses contados do registro da Incorporação (previsão out/29). O registro da Incorporação por sua vez deverá ocorrer em até 60 dias após a lavratura da EVC;
  - Caso o montante repassado até o 36º mês contado do RI seja inferior ao valor de R$ 6.000.000,00 deveremos completar o valor faltante em 1 parcela no 30º dia do mês seguinte;
  - Caso o montante repassado até o 36º mês contado do RI seja igual ou superior ao valor de R$ 6.000.000,00 nada será devido e o contrato será encerrado.
  - O negócio não é Preço Certo, e caso os repasses até o 36º mês após RI ultrapassem o valor do PMG, os vendedores receberão mais que R$ 8.600.000,00. Fluxo de repasses está abaixo do valor do PMG, de modo que estamos considerando em VF uma parcela para acerto de contas no valor aproximado de R$ 780.000,00 no 36º mês após RI para completar o PMG;
  - Independente do fluxo de pagamento os repasses serão encerrados no mês 36 contado do registro do RI;

➢ PRAZOS CONTRATUAIS

- Etapa I: Prazo 120 dias para resolutivas técnica, jurídica e renovação do alvará de vendas pelo prazo de 22 meses em igualdade com o prazo descrito em CVC; (previsão mar/25)
- Etapa II: Em até 18 meses após a superação da Etapa I para aprovação de projeto, contratação CEF, análise técnica, financeira e comercial para o lançamento do empreendimento (previsão CVC set/26 + prorrogações à critério da Tenda/ previsão Leg set/26);
- Conforme cláusula 6.2 do CVC assinado podemos suspender os prazos contratuais mediante envio de comunicação por escrito em caso de não superação de qualquer condição resolutiva à critério da Tenda pelo prazo que for necessário, suspendo as obrigações de pagamento e lavratura da escritura;

➢ GARANTIAS

- Carta Fiança com prazo de vigência anual para garantia do valor inicial de R$ 6.000.000,00 (em VF está sendo considerado *cash collateral*);

➢ CORRETAGEM

- R$ 430.000,00 em 5 parcelas mensais, iguais, consecutivas e fixas a partir da lavratura da EVC;

Condições do Negócio

➢ RESOLUTIVAS DO CONTRATO

I - Em até 120 (cento e vinte) dias a contar da assinatura do presente instrumento (previsão CVC mar/25 + prorrogações à critério da Tenda/ previsão Leg mar/25):

i. a prolação de decisão judicial nos Autos da Interdição indeferindo o pedido de renovação do alvará judicial autorizando a venda da fração de titularidade do Imóvel de FERNANDO nos moldes já determinados e/ou a prorrogação do respectivo prazo de validade por 22 (vinte e dois) meses adicionais; (superado)
ii. a existência de ação de desapropriação e/ou declaração de utilidade pública que objetive o Imóvel ou parte dele; (superado)
iii. a existência de cadastro como imóvel tombado e/ou em processo de tombamento e/ou em áreas envoltórias, no IPHAN, CONDEPHAAT ou CONPRESP, que impossibilitem a adequada consecução do Empreendimento; (superado)
iv. a não apresentação da documentação e/ou esclarecimentos indicados nas cláusulas 3.1, 3.2, 3.2.1 e 3.4 e no ANEXO I pelos VENDEDORES no prazo ali indicado ou a existência de qualquer apontamento nos documentos e certidões forenses que objetive, onere e/ou possa trazer vício à cadeia dominial do Imóvel e/ou possam reduzir os VENDEDORES ao estado de insolvência civil, ou que traga insegurança jurídica na operação objeto deste instrumento, a exclusivo critério da COMPRADORA; (superado)
v. a impossibilidade da realização do estudo de passivo ambiental ou a existência de qualquer tipo de contaminação do solo, subsolo e águas do Imóvel, bem como qualquer outro tipo de passivo ambiental e/ou impossibilidade de remoção de árvores que comprometam o Empreendimento que a COMPRADORA pretende desenvolver no Imóvel; (previsão mar/25):
vi. a existência de óbice e/ou condições técnicas e/ou urbanísticas impeditivas à consecução do Empreendimento imobiliário almejado pela COMPRADORA no Imóvel; (superado)
vii. a não viabilidade das redes de água e esgoto existentes no local, que sejam tidas como insuficientes a garantir a vazão necessária às unidades autônomas que comporão o Empreendimento pretendido; (superado)
viii. a não viabilidade de rede elétrica para abastecimento do futuro Empreendimento; (superado)
ix. a não viabilidade de execução da drenagem ou não permissão de passagem em terreno de terceiros; (superado)
x. caso o gabarito de altura pretendido para o Empreendimento pretendido não seja aprovado no DECEA (Departamento de Controle do Espaço Aéreo) e COMAER (Comando da Aeronáutica); (superado)
xi. caso o presente negócio não seja aprovado pelo Comitê de Investimentos da COMPRADORA; (previsão mar/25):

Condições do Negócio

➢ RESOLUTIVAS DO CONTRATO

II – Em até 18 (dezoito) meses a contar da superação das condições descritas no item "I", supra (previsão CVC set/26 + prorrogações à critério da Tenda; previsão Leg set/26):

xii. caso as Partes não logrem promover eventuais regularizações relativas aos Imóvel, necessárias para a consecução do Empreendimento pretendido;
xiii. caso seja constatada pela COMPRADORA a existência de terceiros ocupantes nos Imóvel, existindo pessoas e coisas, que impeçam a transferência da posse para a COMPRADORA de forma inteiramente livre e desimpedida, nos termos previstos no presente instrumento;
xiv. o não aperfeiçoamento de quaisquer das condições resolutivas, relativas ao terreno e ao Empreendimento, abaixo relacionadas:
(a) análise da viabilidade técnica e financeira do Empreendimento;
(b) análise da viabilidade comercial do Empreendimento;
(c) verificação da manutenção da segurança jurídica, observado o previsto nos termos da Cláusula 3.5, supra.
xv. a não aprovação nos termos da legislação vigente do projeto do Empreendimento pela Prefeitura Municipal e demais órgãos competentes, necessários para viabilizar sua edificação, mediante a obtenção de todas as licenças necessárias para tal fim e/ou exigências pela Prefeitura Municipal de obrigações adicionais não contempladas no projeto apresentado e/ou de contrapartida que acarrete a inviabilidade financeira do Empreendimento pretendido pela COMPRADORA;
xvi. a não apresentação pelos VENDEDORES de alvará judicial autorizando a venda da cota parte do Imóvel de titularidade de FERNANDO nos moldes já determinados pelo juízo competente, com prazo de validade até a data prevista para a celebração da Escritura de Compra e Venda, observado o disposto na cláusula 5.1, supra; e
xvii. a inviabilidade de contratação de financiamento pela instituição financeira para construção do Empreendimento, consoante os termos e condições do Programa do Governo Federal Minha Casa Minha Vida ou qualquer outro que venha a substituí-lo.

Fluxo de Pagamento VF – Cash

Pagamento Terreno Consolidado			
	Total Terreno	(2.600.000)	
	Sinal R$	-	
	Data Sinal	0	
	Prazo de carência (meses)	20	
	Nº Parcelas (unid)	1	
	Valor parcelas (R$)	(2.600.000)	
0	dez/24	-	Compra Terreno
1	jan/25	-	
2	fev/25	-	
3	mar/25	-	
4	abr/25	-	
5	mai/25	-	
6	jun/25	-	
7	jul/25	-	
8	ago/25	-	
9	set/25	-	
10	out/25	-	
11	nov/25	-	
12	dez/25	-	
13	jan/26	-	
14	fev/26	-	
15	mar/26	-	
16	abr/26	-	
17	mai/26	-	
18	jun/26	-	
19	jul/26	-	
20	ago/26	-	
21	set/26	(2.600.000)	Escritura
22	out/26	-	Lançamento
23	nov/26	-	
24	dez/26	-	
25	jan/27	-	
26	fev/27	-	
27	mar/27	-	
28	abr/27	-	Início Obra
29	mai/27	-	
30	jun/27	-	
31	jul/27	-	
32	ago/27	-	
33	set/27	-	
34	out/27	-	
35	nov/27	-	
36	dez/27	-	
37	jan/28	-	
38	fev/28	-	
39	mar/28	-	
40	abr/28	-	
41	mai/28	-	
42	jun/28	-	
43	jul/28	-	
44	ago/28	-	
45	set/28	-	
46	out/28	-	
47	nov/28	-	
48	dez/28	-	
49	jan/29	-	
50	fev/29	-	
51	mar/29	-	
52	abr/29	-	
53	mai/29	-	
54	jun/29	-	
55	jul/29	-	
56	ago/29	-	
57	set/29	-	
58	out/29	-	Chaves

R$ 2.600.000,00 vinculado à Escritura

Pareceres

Análise da Mancha e Implantação

Prospecção

Operações

Inteligência de Mercado

Financeiro

Anexos

Custo de Construção

	ESSENCE BUTANTÃ CEN. 02 | R01	ESSENCE BUTANTÃ CEN. 01 | R00	HORIZONTE JARAGUÁ CEN. 02 | R03	SOBRAL CEN. 08 | R21
Torres	1	1	1	2
Unidades Construídas	416	364	520	588
Unidades Vendidas	409	357	514	577
Condomínios (qta.)	1	1	1	1
Cidade	São Paulo - SP	São Paulo - SP	São Paulo - SP	São Paulo - SP
Produto / Selo	F2EPlus- V0200 CDW	F2EPlus- V0200 CDW	F2EPlus- V0200 CDW	F2EPlus- V0200 CDW
Atributos de Projeto	Varanda - 175 uh	-	-	-
Tipologia	1 Torre em L | T+25 | 16PP	1 Torre em L | T+25 | 14PP	1 Torre | T+25 | 20PP	1 Torre | T+24 | 12PP
Tipologia	-	-	-	1 Torre | T+23 | 12PP
Projeto Infra	AP	AP	AP	AP
Projeto Torre	AP	AP	AP	AP/EM
Mês Base	março-25	dezembro-24	janeiro-25	janeiro-25
Incc	1.173,775	1.153,725	1.159,536	1.159,536
LVS	janeiro-25	outubro-24	novembro-24	novembro-24
Indiretos	janeiro-25	outubro-24	novembro-24	novembro-24
Base de Preço	LPU 88	LPU 85	LPU 86	LPU 86
Takt	2x2	2x2	2x2	2x2
Prazo (mês)	22	19	29	23
CUSTO TOTAL I	R$ / UND R$ 105.504	R$ / UND R$ 102.022	R$ / UND R$ 102.719	R$ / UND R$ 100.450
Indireto	R$ 24.430	R$ 23.631	R$ 21.565	R$ 19.100
Torre	R$ 62.817	R$ 61.438	R$ 60.267	R$ 63.620
Infra	R$ 11.551	R$ 10.895	R$ 11.851	R$ 9.578
Fundação	R$ 5.694	R$ 5.409	R$ 5.742	R$ 6.827
EEE			R$ 721	
ETE				
Contenção	R$ 232	R$ 248	R$ 300	R$ 364
Terraplenagem	R$ 780	R$ 400	R$ 2.272	R$ 960
CUSTO TOTAL II	R$ 1.249	R$ 1.315	R$ 1.625	R$ 1.326
Urbanização	R$ 239	R$ 225	R$ 34	R$ 133
Drenagem				R$ 15
Extensão de Rede Elétrica	R$ 306	R$ 337	R$ 243	R$ 234
Extensão de Rede Hidráulica	R$ 704	R$ 753	R$ 1.348	R$ 944
CUSTO TOTAL III				
Incorridos				
CUSTO TOTAL IV				
Aprendizado				
CUSTO TOTAL V		R$ 1.796	R$ 1.281	R$ 1.250
Atualização por INCC		R$ 1.796	R$ 1.281	R$ 1.250
CUSTO TOTAL I+II	R$ 106.752	R$ 103.338	R$ 104.343	R$ 101.776
CUSTO TOTAL I AO IV	R$ 106.752	R$ 105.133	R$ 105.625	R$ 103.026

Custo de Construção

	ESSENCE BUTANTÃ CEN. 02 | R01	ESSENCE BUTANTÃ CEN. 01 | R00	
Torres	1	1	
Unidades Construídas	416	364	
Unidades Vendidas	409	357	
Condomínios (qta.)	1	1	
Cidade	São Paulo - SP	São Paulo - SP	
Produto / Selo	F2EPlus- V0200 CDW	F2EPlus- V0200 CDW	
Atributos de Projeto	Varanda - 175 uh	-	
Tipologia	1 Torre em L | T+25 | 16PP	1 Torre em L | T+25 | 14PP	
Projeto Infra	AP	AP	
Projeto Torre	AP	AP	
Mês Base	março-25	dezembro-24	
Incc	1173,78	1153,73	
LVS	janeiro-25	outubro-24	
Indiretos	janeiro-25	outubro-24	
Base de Preço	LPU 88	LPU 85	
Takt	2x2	2x2	
Prazo (mês)	22	19	
CUSTO TOTAL I	R$ / UND R$ 105.504	R$ / UND R$ 102.022	DIF R$ 3.481
Indireto	R$ 24.430	R$ 23.631	R$ 798
Torre	R$ 62.817	R$ 61.438	R$ 1.379
Infra	R$ 11.551	R$ 10.895	R$ 655
Fundação	R$ 5.694	R$ 5.409	R$ 285
EEE	R$ 0	R$ 0	R$ 0
ETE	R$ 0	R$ 0	R$ 0
Contenção	R$ 232	R$ 248	-R$ 17
Terraplenagem	R$ 780	R$ 400	R$ 380
CUSTO TOTAL II	R$ 1.249	R$ 1.315	-R$ 66
Urbanização	R$ 239	R$ 225	R$ 14
Drenagem	R$ 0	R$ 0	R$ 0
Extensão de Rede Elétrica	R$ 306	R$ 337	-R$ 31
Extensão de Rede Hidráulica	R$ 704	R$ 753	-R$ 49
CUSTO TOTAL III	R$ 0	R$ 0	R$ 0
Incorridos	R$ 0	R$ 0	R$ 0
CUSTO TOTAL IV	R$ 0	R$ 0	R$ 0
Aprendizado	R$ 0	R$ 0	R$ 0
CUSTO TOTAL V	R$ 0	R$ 1.796	-R$ 1.796
Atualização por INCC	R$ 0	R$ 1.796	-R$ 1.796
CUSTO TOTAL	R$ 106.752	R$ 105.133	R$ 1.619

INDIRETOS
-157 | G11 – Serviços Técnicos (Diluição)
+416 | G13 – Pessoal Permanente (Preço)
+696 | G14 – Administração (Alteração de QC – QLP Revisado para refeição | Preço – Dissídio Vigilância e Limpeza)
-348 | G15 – Canteiro (Diluição)
+616 | G16 – SSO (Alteração de Premissa SSO – Inclusão do SLQA)
-557 | G17 – Equipamentos (Alteração de QC – Maquinário Apoio Baldrame)
-118 | G18 – Ensaios (Diluição)
+283 | G19 – Transporte e Limpeza (Alteração de QC – Aumento do consumo de caçambas e taxa de destinação)

TORRE
+129 | Vertical (LVS Jan/2025 x Out/2024)
+605| Aço (Preço – LPU 86 x LPU 88)
CEN01: 58 kg/m³ - 6,27 R$/kg
CEN02: 50 kg/m³ - 6,43 R$/kg
+357 | Concreto (m³/uh e Preço – LPU 85 x LPU 88)
CEN01: 12,60 m³/uh – Preço médio R$700 /m³
CEN02: 13,02 m³/uh – Preço médio R$708 /m³
-395 | Gesso (Alteração de QC – Troca do Shaft do Apto de EPS para Drywall)
+171 | Esquadrias de Madeira (Preço + Inclusão de Ferragens)
+514 | Esquadrias de Alumínio (Porta de Alumínio Varanda)
+279 | Esquadrias de Ferro (Guarda Corpo Varanda)
+489 | Instalações Torre (LVS Jan/2025 x Out/2024)
-885 | Elevador (Tipologia)
CEN01: 14PP – 3+3 elev. /torre | 1,5m/s + 1,75 m/s – **6.174 R$/U.H**
CEN02: 16PP – 3+3 elev. /torre | 1,75m/s + 2,5 m/s – **5.381 R$/U.H**

INFRA
+1.274| Instalações Infra (LVS Jan/2025 x Out/2024)
-323 | Reservatório Metálico (Projeto e Diluição)
CEN01: 1 Reservatório c/ altura de 24,43m - Ø 3.18 m
CEN02: 2 Reservatórios c/ altura de 9,88m - Ø 3.50 m
-117 | Anexos (Diluição)

FUNDAÇÃO
+285 | Projeto
CEN01: EHC Ø 50, 60 e 70 cm – 18 a 22m – 175 unid. – Total 3.514m – R$375/m
Baldrame: 3.785 R$/m³ - H= 0,25cm – 170,70 kg/m³
CEN02: EHC Ø 50, 60 e 80 cm – 13 a 16m – 236 unid. – Total 3.333m – R$429/m
Baldrame: 3.537 R$/m³ - H= 0,25cm – 170,00 kg/m³

TERRAPLENAGEM
+380 | Projeto
CEN01: Corte 1.080m³ | Aterro 115m³
CEN02: Corte 1.376m³ | Aterro 216m³ + Movimentação de Terra Baldrame

Custo de Construção

	ESSENCE BUTANTÃ CEN. 02 | R01	HORIZONTE JARAGUÁ CEN. 02 | R03	
Torres	1	1	
Unidades Construídas	416	520	
Unidades Vendidas	409	514	
Condomínios (qta.)	1	1	
Cidade	São Paulo - SP	São Paulo - SP	
Produto / Selo	F2EPlus- V0200 CDW	F2EPlus- V0200 CDW	
Atributos de Projeto	Varanda - 175 uh	-	
Tipologia	1 Torre em L | T+25 | 16PP	1 Torre | T+25 | 20PP	
Projeto Infra	AP	AP	
Projeto Torre	AP	AP	
Mês Base	março-25	janeiro-25	
Incc	1173,78	1159,54	
LVS	janeiro-25	novembro-24	
Indiretos	janeiro-25	novembro-24	
Base de Preço	LPU 88	LPU 86	
Takt	2x2	2x2	
Prazo (mês)	22	29	
CUSTO TOTAL I	R$ / UND R$ 105.504	R$ / UND R$ 102.719	DIF R$ 2.785
Indireto	R$ 24.430	R$ 21.565	R$ 2.865
Torre	R$ 62.817	R$ 60.267	R$ 2.550
Infra	R$ 11.551	R$ 11.851	-R$ 300
Fundação	R$ 5.694	R$ 5.742	-R$ 48
EEE	R$ 0	R$ 721	-R$ 721
ETE	R$ 0	R$ 0	R$ 0
Contenção	R$ 232	R$ 300	-R$ 69
Terraplenagem	R$ 780	R$ 2.272	-R$ 1.492
CUSTO TOTAL II	R$ 1.249	R$ 1.625	-R$ 376
Urbanização	R$ 239	R$ 34	R$ 205
Drenagem	R$ 0	R$ 0	R$ 0
Extensão de Rede Elétrica	R$ 306	R$ 243	R$ 62
Extensão de Rede Hidráulica	R$ 704	R$ 1.348	-R$ 643
CUSTO TOTAL III	R$ 0	R$ 0	R$ 0
Incorridos	R$ 0	R$ 0	R$ 0
CUSTO TOTAL IV	R$ 0	R$ 0	R$ 0
Aprendizado	R$ 0	R$ 0	R$ 0
CUSTO TOTAL V	R$ 0	R$ 1.281	-R$ 1.281
Atualização por INCC	R$ 0	R$ 1.281	-R$ 1.281
CUSTO TOTAL	R$ 106.752	R$ 105.625	R$ 1.128

INDIRETOS
+443 | G11 – Serviços Técnicos (Diluição)
-459 | G13 – Pessoal Permanente (Horizonte Jaraguá possui equipe para aterro de pré carga)
+1.720 | G14 – Administração (Alteração de QC – QLP Revisado para refeição + VB Pad Mounted)
+554 | G15 – Canteiro (Diluição)
+527 | G16 – SSO (Alteração de Premissa SSO – Inclusão do SLQA)
-330 | G17 – Equipamentos (Itens Logística – Horizonte possui Munck em todo prazo de forma e pós forma)
+331 | G19 – Transporte e Limpeza (Alteração de QC – Aumento do consumo de caçambas e taxa de destinação)

TORRE
+517 | Aço (Preço – LPU 86 x LPU 88)
Essence: 50 kg/m³ - 6,43 R$/kg
Horizonte: 51 kg/m³ - 6,27 R$/kg
+513 | Concreto (m³/uh e Preço – LPU 86 x LPU 88)
Essence: 13,02 m³/uh – Preço médio R$708 /m³
Horizonte: 9,08 m³/U.H – Preço médio R$671 /m³
-110 | Gesso (Alteração de QC – Troca do Shaft do Apto de EPS para Drywall)
+254 | Esquadrias de Madeira (Preço + Inclusão de Ferragens)
+527 | Esquadrias de Alumínio (Porta de Alumínio Varanda)
+138 | Esquadrias de Ferro (Guarda Corpo Varanda)
+794 | Instalações Torre (LVS Jan/2025 x Nov/2024)

INFRA
+1.365 | Instalações Infra (LVS Jan/2025 x Nov/2024)
-402 | Reservatório Metálico (Projeto)
Essence: 2 Reservatórios c/ altura de 9,88m - Ø 3.50 m
Horizonte: 2 Reservatórios c/ altura de 16,60m - Ø 3.18 m
-912 | Anexos (Projeto)
Essence: Fundação dos Anexos em Radier com troca de solo 1m
Horizonte: Fundação dos Anexos em EHC Ø50 – Comp. 18m
-131 | Enterrados (Projeto)
Essence: 1 Tanque de Reuso | 1 Tanque de Retardo
Horizonte: 2 Tanque de Reuso | 2 Tanque de Retardo

TERRAPLENAGEM
-1.492 | Projeto
Essence: Corte 1.080m³ | Aterro 115m³
Horizonte: Corte 819 m³ | Aterro 3.305 m³ | Aterro de Pré Carga 1.392 m³

Operações

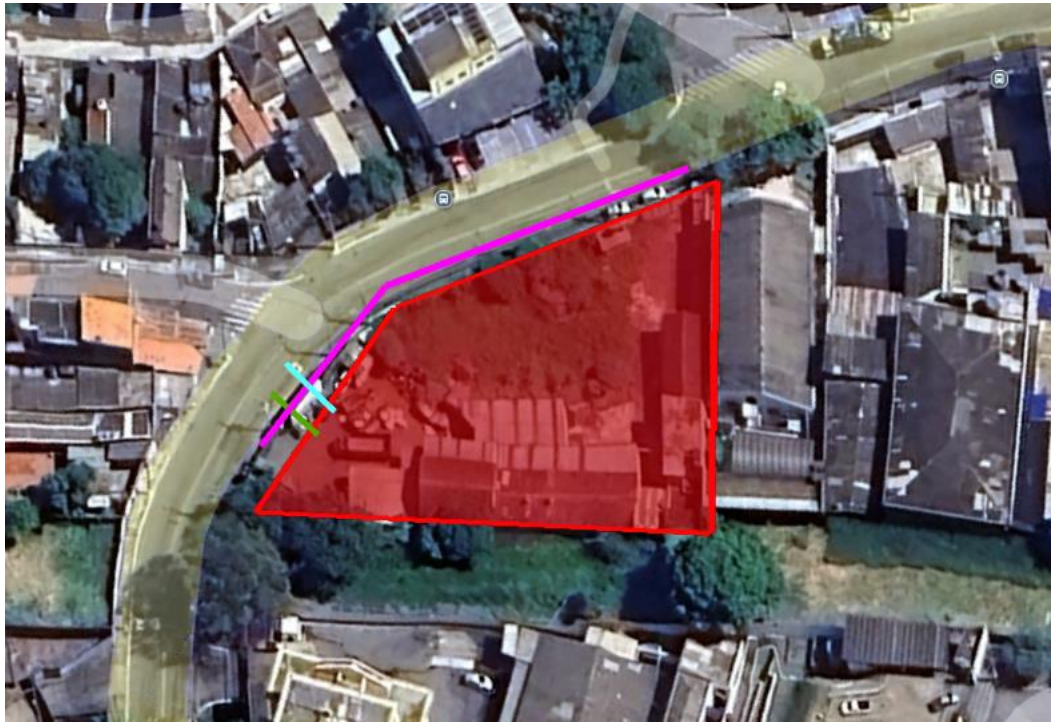

SISTEMA DE ABASTECIMENTO DE ÁGUA
Ligação na porta.

SISTEMA DE ESGOTAMENTO SANITÁRIO
Ligação na porta.

SISTEMA DE DRENAGEM
Drenagem será por gravidade na sarjeta da Av. Heitor Eiras Garcia.

SISTEMA DE ABASTECIMENTO DE GÁS
Devido a falta de espaço físico para locar os cilindros de GLP, foi considerado gás encanado após verificação de existência de rede na rua.

SISTEMA DE ABASTECIMENTO ELÉTRICO
Sem viabilidade. Considerada VB de 125K.

TERRENO

URBANIZAÇÃO
Considerado calçada na testada do empreendimento.

Operações

Matriz Risco Concessionária	
Água	Nível 3
Esgoto	Nível 3
Drenagem	NA
Elétrica	Nível 5
Gás	NA
Urbanização	NA

LEGENDA		
Nível	Tipo	Status
1	Com Diretriz	Conclusiva
2		Conclusiva com projeto aprovado
3		Conclusiva sem projeto aprovado
4		Não Conclusiva
5	Sem Diretriz	-
NA	-	Não aplicável

Água:
- Viabilidade emitida em 12/2024, com validade em 12/2026. A viabilidade emitida é para 358 uh, cenário atual possui 409uh.

Esgoto:
- Viabilidade emitida em 12/2024, com validade em 12/2026. A viabilidade emitida é para 358 uh, cenário atual possui 409uh.

Drenagem:
- Drenagem será por gravidade na sarjeta da Av Heitor Erias Garcia.

Elétrica:
- Sem viabilidade, foi considerada VB de 125K. No pedido de ligação definitiva a concessionária pode vir a cobrar reformas necessárias, caso a infraestrutura existente não seja suficiente.

Gás:
- Devido a falta de espaço físico para locar os cilindros de GLP, foi considerado gás encanado, após verificação de existência de rede na rua.

Urbanização:
- Considerada calçada na testada do empreendimento.

Fundação:
- Realizada campanha de sondagem contemplando 02 furos. Necessário sondagem complementar.
- Considerada Estaca Hélice, com diâmetros de 50, 60 e 80 cm e profundidade de 13 à 16 m.

Logística

MODULAÇÃO E TOMBAMENTO

1 : 750

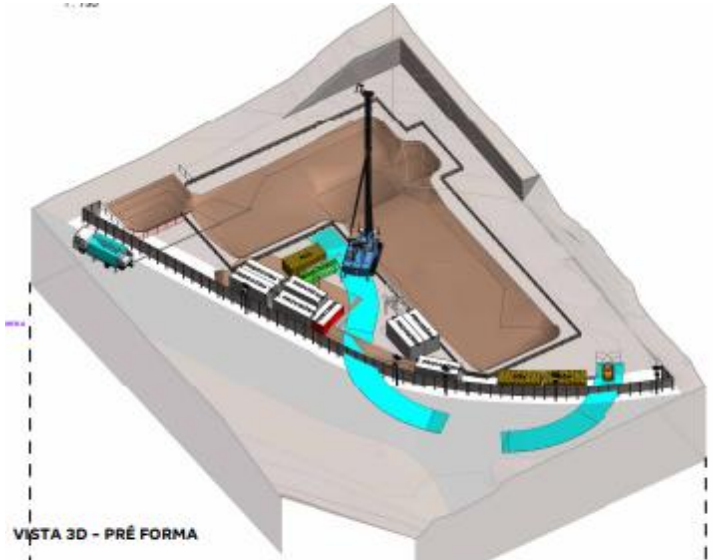

VISTA 3D - PRÉ FORMA

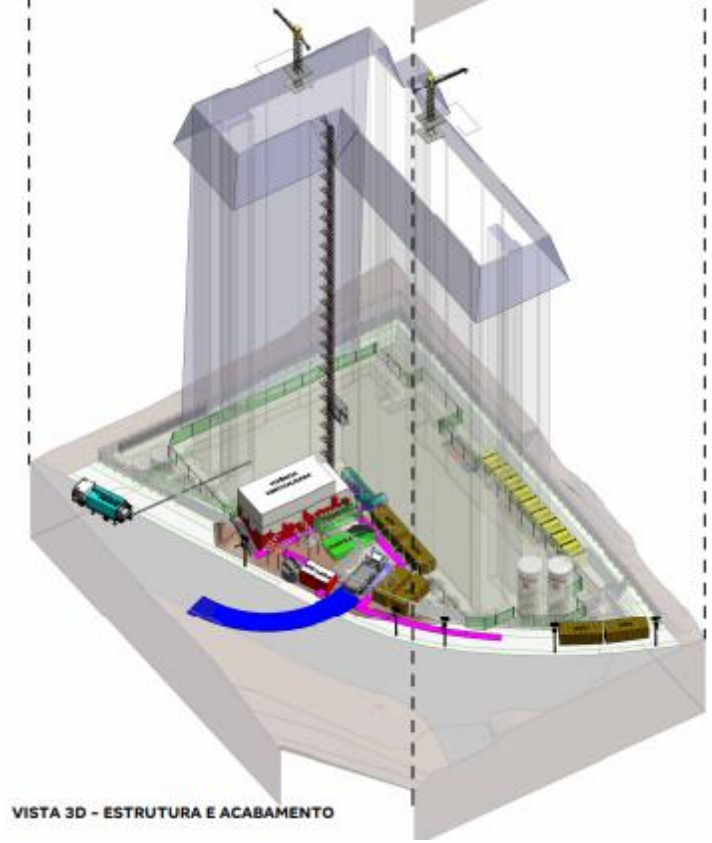

VISTA 3D - ESTRUTURA E ACABAMENTO

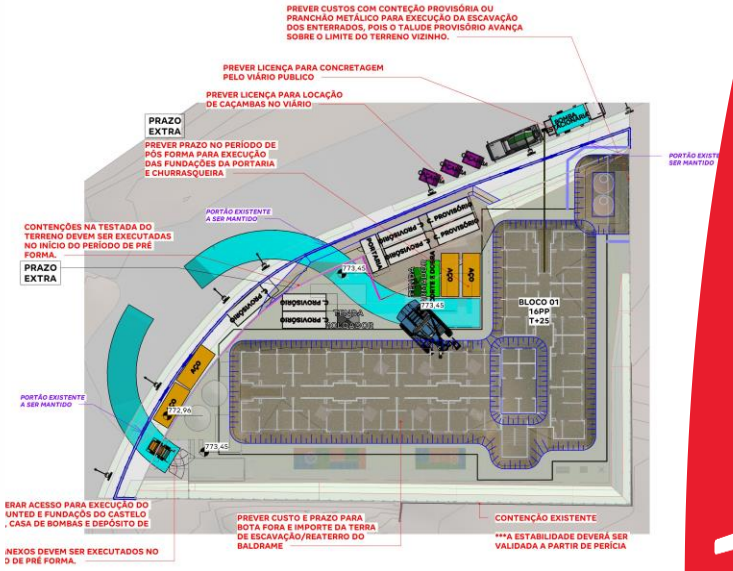

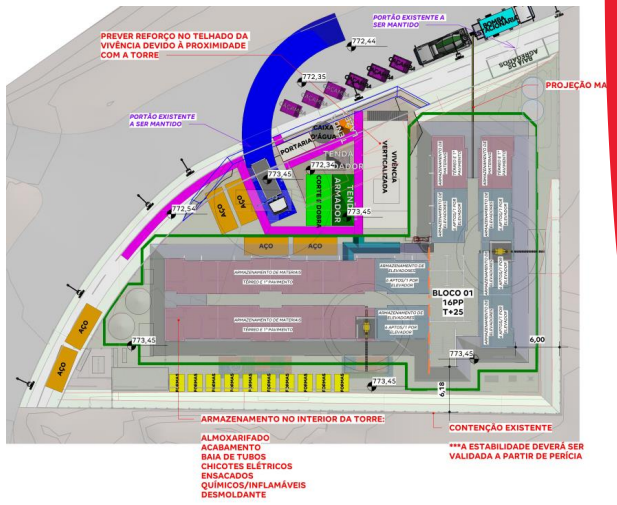

VIVÊNCIA - CONTAINERS									
DESCRIÇÃO	QUANTIDADE	TAMANHO MÓDULOS	MOBILIZAÇÃO	DESMOBILIZAÇÃO	PRÉ FORMA	ESTRUTURA	ACAB.	FASE	CÓDIGO ORÇAMENTO
CONTAINER PORTARIA (LOG)	CONSIDERAR 1 MÓDULO COM SANITÁRIO E CATRACA	2,41 X 4,90 m	1 MOBILIZAÇÃO	1 DESMOBILIZAÇÃO	TODO PERÍODO	TODO PERÍODO	TODO PERÍODO		
CONTAINER PROVISÓRIO (LOG)	CONSIDERAR 8 MÓDULOS DE CONTAINER	2,41 X 6,10 m	1 MOBILIZAÇÃO	1 DESMOBILIZAÇÃO	TODO PERÍODO	-	-		
CONTAINER VIVÊNCIA VERTICALIZADA (LOG)	CONSIDERAR 17 MÓDULOS DE CONTAINERS E 1 ESCADA PARA ACESSO (SENDO 6 NO PAV T., 6 NO PAV 1 E 5 NO ULTIMO PAV.)	2,41 X 6,10 m	1 MOBILIZAÇÃO	1 DESMOBILIZAÇÃO	-	TODO PERÍODO	TODO PERÍODO		

TENDAS_PERÍODOS								
DESCRIÇÃO	QUANTIDADE	LARGURA	COMPRIMENTO	PRÉ FORMA	ESTRUTURA	ACABAMENTO	FASE	CÓDIGO ORÇAMENTO
TENDA ARMADOR (LOG)	2	<varia>	<varia>	TODO PERÍODO	TODO PERÍODO	-		
TENDA LAZER (LOG)	1	2,00	2,00	-	TODO PERÍODO	TODO PERÍODO		
TENDA MOLDADOR (LOG)	2	2,00	<varia>	TODO PERÍODO	TODO PERÍODO	-		

LOG_EQUIPAMENTOS E MAQUINÁRIOS								
EQUIPAMENTO	QUANTIDADE	MOBILIZAÇÃO	DESMOBILIZAÇÃO	PRÉ FORMA	ESTRUTURA	ACABAMENTO	FASE	CÓDIGO ORÇAMENTO
BETONEIRA (LOG)	VARIÁVEL	-	-	TODO PERÍODO	TODO PERÍODO	-		
BOBCAT (LOG)	1 EQUIPAMENTO	1 MOBILIZAÇÃO	1 DESMOBILIZAÇÃO	-	TODO PERÍODO	CONSIDERAR 15 DIAS DO PERÍODO DE ACABAMENTO		
BOMBA ESTACIONÁRIA PADRÃO (LOG)_R01	1 EQUIP PARA O BLOCO X	-	-	-	TODO PERÍODO	-		
CAMINHÃO MUNCK (LOG)	1 EQUIPAMENTO	1 MOBILIZAÇÃO	1 DESMOBILIZAÇÃO	-	CONSIDERAR MEIO PERÍODO DE ESTRUTURA	-		
CREMALHEIRA PCT (LOG)	1 EQUIP	1 MOBILIZAÇÃO	1 DESMOBILIZAÇÃO	-	TODO PERÍODO	TODO PERÍODO		
MINIGRUA (LOG)	2 EQUIP	1 MOB POR MINIGRUA POR TORRE (TAKT 2X2)	1 DESMOB POR MINIGRUA POR TORRE (TAKT 2X2)	-	TODO PERÍODO	-		

Logística

EIRAS GARCIA – SP

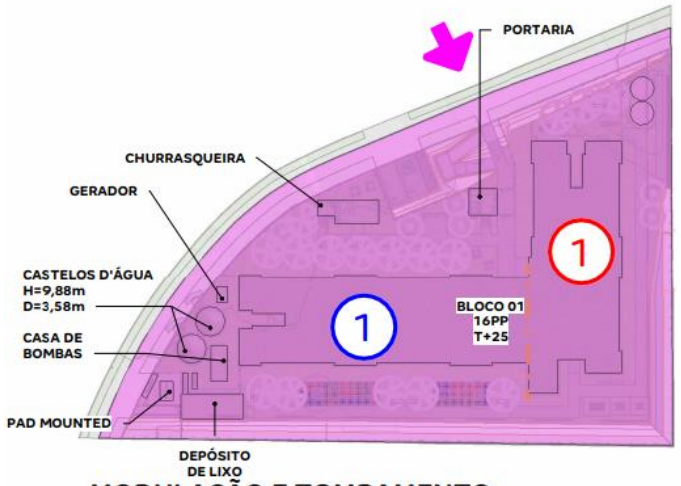

MODULAÇÃO E TOMBAMENTO

1 : 750

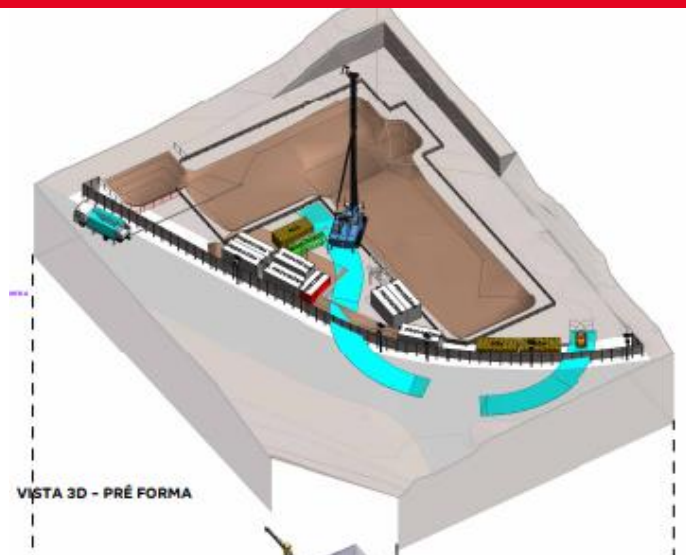

VISTA 3D - PRÉ FORMA

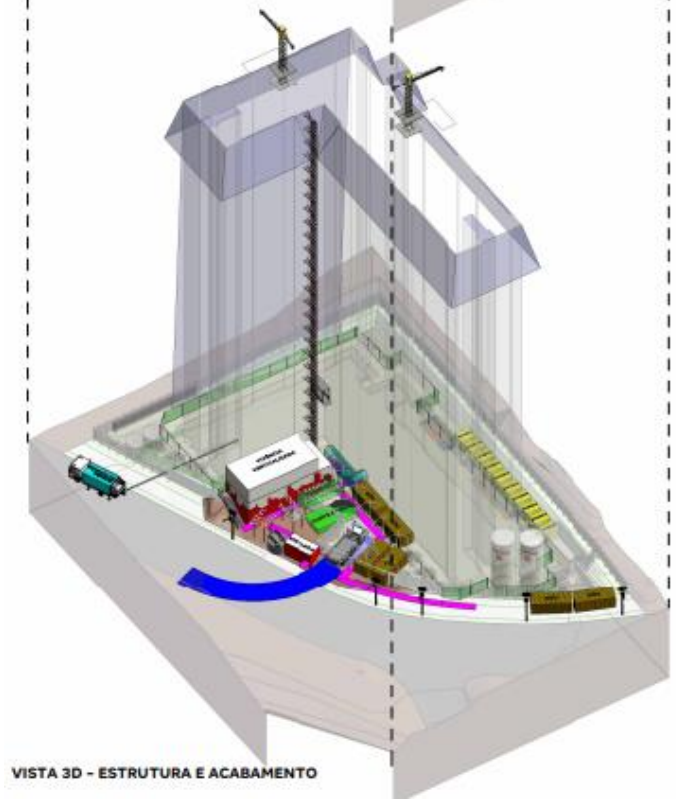

VISTA 3D - ESTRUTURA E ACABAMENTO

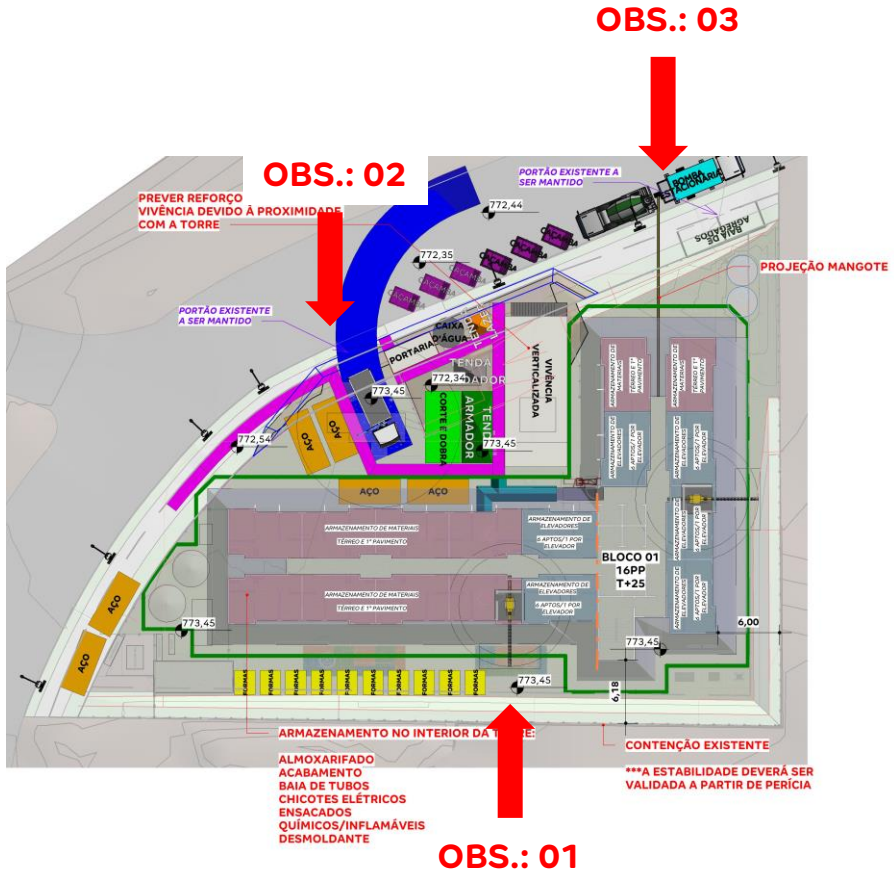

➢ OBS. 01	PREVER CUSTO E PRAZO PARA BOTA FORA E IMPORTE DA TERRA DE ESCAVAÇÃO/REATERRO DO BALDRAME
➢ OBS. 02	PREVER PRAZO NO PERÍODO DE PÓS FORMA PARA EXECUÇÃO DAS FUNDAÇÕES DA PORTARIA E CHURRASQUEIRA
➢ OBS. 03	PREVER LICENÇA PARA CONCRETAGEM PELO VIÁRIO PUBLICO

Logística

ITENS A SEREM CONSIDERADOS:

➢ **LEGALIZAÇÃO**	DEVIDO À QUANTIDADE DE ÁRVORES DE COMPENSAÇÃO PREVISTAS NESTA IMPLANTAÇÃO, DEVERÁ SER PREVISTO PRAZO ADICIONAL CONFORME AVALIAÇÃO DE LEGALIZAÇÃO E PÓS-LEG PARA NÍVEL DE CRITICIDADE 2 (ITENS DE LOGÍSTICA SOBREPONDO ÁRVORES E ÁREA PERMEÁVEL). PREVER LICENÇA PARA UTILIZAÇÃO DO VIÁRIO PÚBLICO DURANTE AS CONCRETAGENS .
➢ **CUSTOS / OBRA**	PREVER CUSTOS COM LOCAÇÃO DE VIVÊNCIA VERTICALIZADA (T+2), DEVIDO À FALTA DE ESPAÇO NA IMPLANTAÇÃO PARA LOCAÇÃO DA VIVÊNCIA PADRÃO. CONSIDERAR 17 MÓDULOS DE CONTAINERS E 1 ESCADA PARA ACESSO (6 CONTAINERS NO PAVIMENTO TÉRREO, 6 NO P1° PAVIMENTO E 5 NO ULTIMO PAVIMENTO). PREVER CUSTO PARA EQUIPE DE MOVIMENTAÇÃO MANUAL DE MATERIAIS "FORMIGUINHAS" (2 FUNCIONÁRIOS ESTRUTURA, 2 FUNCIONÁRIOS ACABAMENTO E 2 FUNCIONÁRIOS PARA TRANSPORTE DE AÇO), DEVIDO À IMPOSSIBILIDADE DE ACESSO DE MAQUINÁRIOS AO LONGO DA IMPLANTAÇÃO PARA MOVIMENTAÇÃO/DESCARGA DE MATERIAIS. PREVER CUSTO DE CONTENÇÃO PROVISÓRIA PARA ENTERRADOS, DEVIDO À SOBREPOSIÇÃO DO TALUDE PROVISÓRIO ORIUNDOS DE SUA ESCAVAÇÃO AVANÇAREM O LIMITE DO LOTE. GETEC DEVERÁ ANALISAR A POSSIBILIDADE DE DESLOCAMENTO DO ENTERRADO, PARA QUE NÃO HAJA ADIÇÃO DE CUSTO DE CONTENÇÕES PROVISÓRIAS.
➢ **PRAZO DE OBRA**	PREVER PRAZO NO PERÍODO DE PRÉ FORMA PARA EXECUÇÃO DE CONTENÇÕES CRÍTICAS (CONFORME INDICADO EM PROJETO).

Pareceres

Análise da Mancha e Implantação

Prospecção

Operações

Inteligência de Mercado

Financeiro

Anexos

Demanda e Distribuição da Mancha

Potencial de Demanda			Lançados		Lançados + Landbank	
Mancha	CÓD.	Shr.	ANO	MÊS	ANO	MÊS
São Paulo Oeste	SZO	52%	398	33	477	40

Empreendimento	Renda	Lançamento	out/26	nov/26	dez/26	jan/27	fev/27	mar/27	abr/27	mai/27	jun/27	jul/27	ago/27	set/27	out/27	nov/27	dez/27	jan/28	fev/28	mar/28	abr/28
Connect Jockey	4.047	ago-25	43	43	43	43	5														
Farol Jaguaré I - F2	3.817	fev-26	38	38	38	38	38	38	38	38	38	38	38	29							
Villa Butantã	3.241	jul-26	40	40	40	40	40	40	40	40	40	40	40	40	40	40	40	27			
Essence Butantã	**4.400**	**out-26**		**23**	**23**	**23**	**23**	**23**	**23**	**23**	**23**	**23**	**23**	**23**	**23**	**23**	**23**	**23**	**23**	**23**	**18**
Total de Vendas Lançados			**0**	**0**	**0**	**0**	**0**	**0**	**0**	**0**	**0**	**0**	**0**	**0**	**0**	**0**	**0**	**0**	**0**	**0**	**0**
Total de Vendas Lançados + Landbank			**121**	**144**	**144**	**144**	**106**	**101**	**101**	**101**	**101**	**101**	**101**	**92**	**63**	**63**	**63**	**50**	**23**	**23**	**18**

Apesar de o total de unidades previsto para a mancha ser maior que o potencial de demanda calculado por I.M, não devemos ter problemas com VSO, pois os projetos Connect Jockey, Villa Butantã e Farol Jaguaré estão na divisa com outras manchas e devem capturar vendas dessas regiões.

Parecer de I.M sobre a mancha:

O projeto analisado em comitê está acima do potencial teórico de demanda calculado para a mancha. (Total Lanç + Landbank)

Canibalização:

Sem Risco de Canibalização

Essence Butantã | Mapa Concorrência

		Essence Butantã	Topic Jaguaré
		TENDA	Econ
	Distância Tenda (km)		2,7km
Região 1 Km	População	46.140	32.196
	Dens. Demográfica	14.782	10.297
	Renda (R$)	9.749	11.502
	Classe Social	B1 (8.1k a 16k)	B1 (8.1k a 16k)
	PEA Dia	29.060	43.462
Quantitativo	Lançamento	out/26	out/22
	Unidades	409	381
	Estoque	409	56
	VSO	23	11
	Stockout	18	5
	Preço Nominal (R$)	253.073	300.000
	Preço CEF (R$)	199.778	240.000
	Renda Comprador (R$)	4.400	5.600
	Dif Tenda (R$)		-1.200
	Factibilidade		●
Qualitativo	Condomínios	1	1
	Torres	1	3
	Gabarito	T+25	T+12
	Plantas (m²)	32m²	37m² e 45m²
	Tipologia	2 Dorms	2 Dorms
	Opções	Não	Não
	Varanda	Sim	Não
	Suite	Não	Não
	Dif. Entrega	Não	Equipado e Decorado
	Vagas	0% de Vagas	0
	Lazer	Play Pet, Churrasqueira Gourmet, Bicicletário Vertical, Play Baby, Play Kids, Salão de Festas Gourmet, Espaço Office, Brinquedoteca, Espaço Saúde, Espaço Teen.	Tem Cobertura, Bosque, Churrasqueira Elétrica, Coworking, Decorado, Fireplace, Mercado, Pet Place, Piscina Aquecida, Pista caminhada, Praça, Sala de Reuniões / Treinamentos, Salão de Festas,

Farol Renda
● Acima de 300
● Entre 0 e 300
● Abaixo de 0

Diagnóstico Concorrência

- A concorrência possui target de preço e renda acima ao previsto para o Eiras Garcia

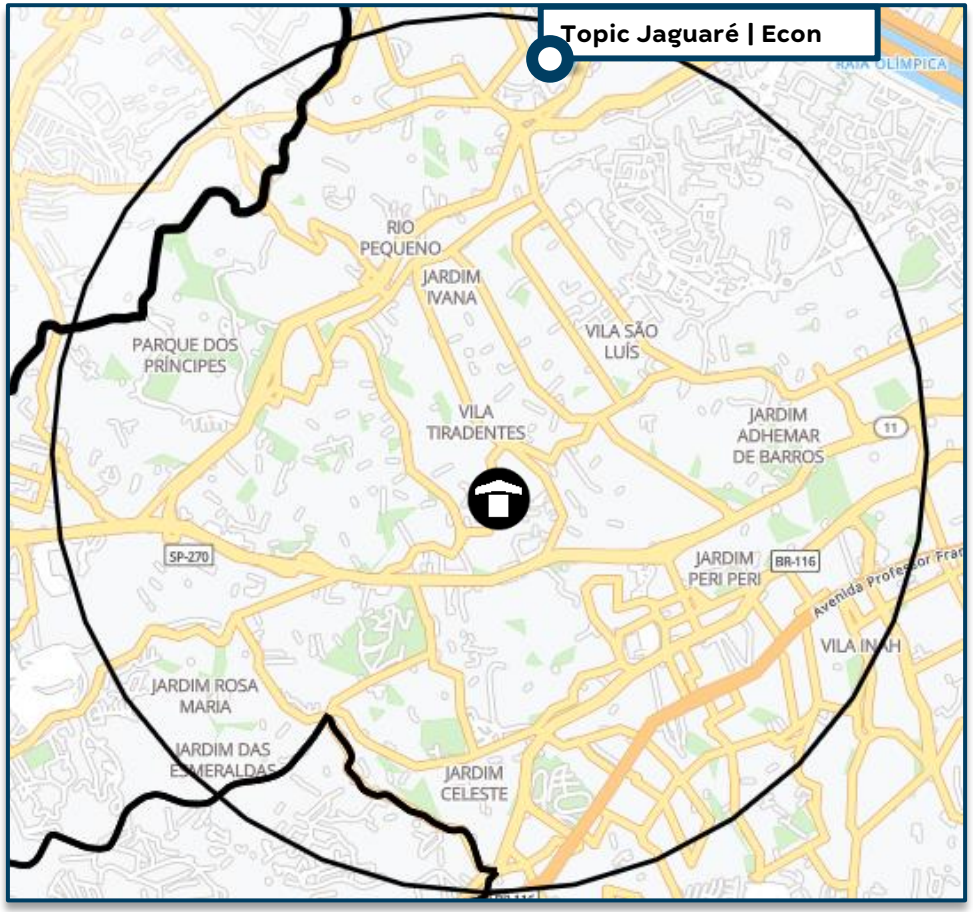

Simulação de Preço

Informações Viabilidade

Projeto:	Essence Butantã					
Tipo:	**HMP**		**HMP - Varanda**		**R2V - Varanda**	
Método	**Vision**		**Vision**		**Vision**	
Avaliação	280.000		320.000		320.000	
Renda Inicial (VF)	3.843		4.585		4.999	
Renda Final*	4.000		4.785		5.199	
% RET1	0%		0%		0%	
Tipo:	**VF**	**R$**	**VF**	**R$**	**VF**	**R$**
Ato	0,86	3.440	0,78	3.736	0,72	3.736
FGTS	0,78	3.095	0,66	3.126	0,62	3.219
Financiamento	98,36%	184.930	96,02%	202.454	95,68%	216.010
Subsídio	163,02%	3.738	0,00%	0	0,00%	0
Prazo de Pró-soluto	27	27	27	27	27	27
Pró-Soluto	81,25%	30.631	80,26%	36.100	80,48%	39.466
Preço Raso (RS)	225.834	225.834	245.416	245.416	262.431	262.431
TCD	24,81%	9.612	54,32%	25.103	49,82%	25.103
VSO	13	13	6	6	4	4
Preço de Venda	**226.632**	**226.632**	**260.393**	**260.393**	**276.770**	**276.770**
Elasticidade	3,889%	3,889%	3,889%	3,889%	3,889%	3,889%
Preço de Venda Final	**235.446**	**235.446**	**270.519**	**270.519**	**287.534**	**287.534**
Preço Raso (R$)	**225.834**		**245.416**		**262.431**	
% de Raso	**95,92%**		**90,72%**		**91,27%**	
BP25 - Não Inflacionado	-		-		-	
BP25 - Inflacionado	-		-		-	

Análise de Preço

Informações Viabilidade

Projeto:	Essence Butantã
Tipo:	**Faixa 2**
Método	**Vision**
Avaliação	297.115
Renda Inicial (VF)	4.224
Renda Final*	4.400

Tipo:	VF	R$
Ato	0,82	3.566
FGTS	0,72	3.123
Financiamento	97,31%	194.516
Subsídio	93,27%	2.139
Prazo de Pró-soluto	27	27
Pró-Soluto	80,86%	33.489
Preço Raso (RS)	236.834	236.834
TCD	36,74%	16.240
VSO	23	23
Preço de Venda	**243.232**	**243.232**
Elasticidade	3,889%	3,889%
Preço de Venda Final	**253.073**	**253.073**
Preço Raso (R$)	**236.834**	
% de Raso	**93,58%**	
Raso Todas as Fases	**236.834**	
Nominal Todas as Fases	**253.073**	

1

Análise de Riscos	Farol IM
IM avalia o Preço Vision como **factível**.	

1) I.M está de acordo com o preço Vision, tendo em vista que, o projeto está em uma região com bons indicadores sociodemográficos, como renda e PEA/Dia, o mesmo também se encontra próximo de pontos de interesses como hospital, escola, mercado e etc. Produto contará com a inclusão de Varanda.

Conforme consta no slide "Panorama de Concorrência", os concorrentes da região vendem em um target de preço e renda acima do previsto para o Produto Tenda.

	Preço Real					Preço Normalizado (27m)		
	Avaliação	Preço Raso	Renda Média	VSO	PSOL	Δ PSOL	Δ Elastic.	Preço Raso
Life Jaguaré	*233.254*	*211.126*	*3.932*	*26*	*26*	*1.062*	*4.019*	*216.207*
Essence Butantã	297.115	236.834	4.400	23	27	-	-	236.834
Connect Jockey*	300.000	234.311	4.690	39	26	*1.321*	*26.860*	*262.492*

Connect Jockey preço e renda previsto em BP, projeto tem abertura de VSO de largada e aumenta o volume posteriormente, utilizado na tabela o VSO médio.

Análise Concorrência

Entorno

Empreendimento Topic ECON

Empreendimento Eiras Garcia TENDA

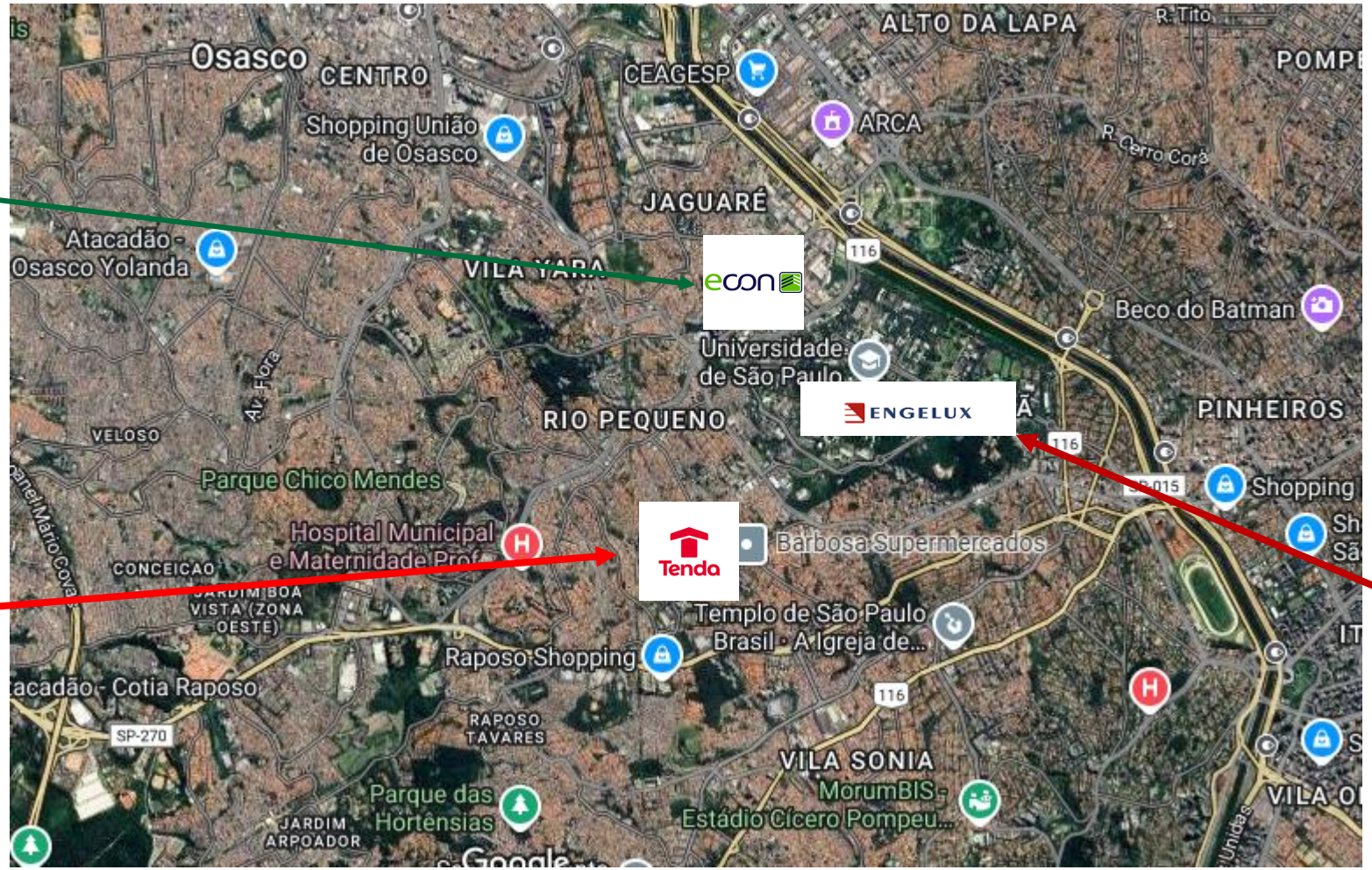

Empreendimento Marco Butantã ENGELUX

Mobilidade

- Estação Vila Sonia
- Estação São Paulo Morumbi

Raio 2Km

- CEU Butanta: 1
- Supermercados: 3
- Escolas Públicas: 3
- Academias: 1

Análise Concorrência

Concorrência 1

Incorporadora	Econ
Nome do produto	Topic Jaguaré
Preço	278.000 a 360.000
Renda	3.900
Estoque	62 UH
Tipologias	HIS2 e R2V

Fluxo	
Ato	10.900
PSOL + TCD	3M (sem TCD)
ITBI	Cobra à parte
Correção	Monetária no valor financiado

Concorrência 2

Incorporadora	Engelux
Nome do produto	Marco Butantã
Preço	273.800 a 418.000
Renda	6.200
Estoque	96 UH
Tipologias	HMP e R2V

Fluxo	
Ato	12.000
PSOL + TCD	36M (sem TCD)
ITBI	Cobra à parte
Correção	Monetária no valor financiado

Parecer do Ciclo:

Concordamos com o parecer emitido por IM, que destaca a baixa concorrência na região. Este fator é de extrema relevância para o planejamento estratégico, pois oferece uma vantagem competitiva significativa para a nossa atuação em preço e volume.

Pareceres

Análise da Mancha e Implantação

Prospecção

Operações

Inteligência de Mercado

Financeiro

Anexos

Informações Financeiras c/ Cash Collateral

Datas e Prazos

	Compra	Lançamento	Início Obra	Término Obra	LÇTO até IO	IO até TO	Chaves	LÇTO até Chaves
Consolidado	dez-24							
HIS s/ Varanda		out-26	abr-27	fev-29	6 meses	22 meses	out-29	36 meses
HMP c/ Varanda		out-26	abr-27	fev-29	6 meses	22 meses	out-29	36 meses
R2V c/ Varanda		out-26	abr-27	fev-29	6 meses	22 meses	out-29	36 meses

Terreno e Incorridos

TOTAL (R$ + Perm.):	9,85 MM	**Incorrido Terreno:**	0,00 MM	**Área do Terreno (100%):**	2.522 m²	**Área Líquida do Terreno:**	2.248 m²
Cash:	2,60 MM			**Custo de terreno m²:**	3.903,5	**Custo de terreno m² Área Líquida:**	4.379,7
Permuta Financeira:	7,25 MM (7,00%)			**VaR 25 (R$ mil):**	0	**Fração Terreno/Terreno + Custo Obra (%VGV):**	9,5% / 51,7%
Permuta Física:	0,00 MM (0,00%)			**VaR 26 (R$ mil):**	0	**CA Máx/Proj.**	4,0 / 5,3
Ato / %VGV:	0,00 MM / 0,0%			**Incorrido de Construção:**	0,00 MM	**Incorridos de Incorporação:**	0,09 MM

Vendas

Fases	Nº Pavimentos	Preço Raso Unit.	Qtde	Preço Unit.	Aval. CEF	Cond. Parcela	% Pró-soluto	% TCD
HIS s/ Varanda	T+25	225.834	234	235.446	280.000	98,4%	81,2%	24,8%
HMP c/ Varanda	T+25	245.416	112	270.519	320.000	96,0%	80,3%	54,3%
R2V c/ Varanda	T+25	262.431	63	287.534	320.000	95,7%	80,5%	49,8%

Unidades Totais:	409	**Preço Médio:**	253.073	**Renda Média:**	4.224	**ITBI+Emol. Unit.:**	5.875
Unidades Tenda:	409	**Avaliação Média:**	297.115	**Ato:**	3.458 (0,82 Salários)	**Custo do Ciclo Unit.:**	15.931
VSO:	23 Unidades	**VGV Total:**	103.507.051	**FGTS:**	3.036 (0,72 Salários)	**Preço Raso Médio:**	236.834
RET Médio:	4,0%	**VGV Tenda:**	103.507.051	**% em RET 1%:**	0%		

Construção

Custo Total Unit.:	106.753	**Eventuais:**	4,00%	**Área priv (m²):**	32,00	**Gape / Mês Unit.:**	11,08

Resultado

LI (R$):	**12.407.993**	**LI:**	**19,99%**	**Exposição de Caixa (R$):**	**13.823.247**	**Margem Bruta Econômica:**	**39,92%**
TIR:	**91,52%**	**LI Aprovação:**	**20,00%**	**Ger. Caixa 12 meses (R$):**	**0**	**Margem Bruta REF:**	**43,69%**
Exposição de Caixa:	**12,40%**	**Δ LI:**	**-0,01%**	**Ger. Caixa 24 meses (R$):**	**(8.615.157)**	**Margem Rasa Econômica:**	**35,24%**
Payback Contingente (21 m):	**20 m/ (-1 m)**	**LI Marginal:**	**20,14%**	**Ger. Caixa Marginal (R$):**	**28.919.044**	**Margem Rasa REF:**	**39,84%**
Payback Consolidado:	**20 meses**					**Margem de Contribuição Econômica:**	**28,28%**

Informações Financeiras c/ Cash Collateral

R$ Mil - Valores Nominais - Compra	Essence Butantã		HIS s/ Varanda		HMP c/ Varanda		R2V c/ Varanda	
	Nominal	%	Nominal	%	Nominal	%	Nominal	%
Receita	111.455	100,0%	59.216	100,0%	32.649	100,0%	19.590	100,0%
PIS/COFINS	(2.445)	2,2%	(1.299)	2,2%	(716)	2,2%	(430)	2,2%
Custo Total	(65.495)	60,1%	(37.306)	64,4%	(17.990)	56,3%	(10.199)	53,2%
Custo Terreno	(9.000)	8,3%	(4.978)	8,6%	(2.526)	7,9%	(1.496)	7,8%
Custo Relacionados a Terreno	(1.165)	1,1%	(646)	1,1%	(328)	1,0%	(190)	1,0%
Custos de Incorporação	(1.623)	1,5%	(954)	1,6%	(429)	1,3%	(240)	1,3%
Custo de Construção	(53.708)	49,3%	(30.728)	53,1%	(14.707)	46,1%	(8.273)	43,2%
Lucro Bruto Econômico	43.515	39,9%	20.611	35,6%	13.943	43,7%	8.961	46,8%
Custo para Rateio	-	0,0%	-	0,0%	-	0,0%	-	0,0%
Lucro Bruto Contábil	43.515	39,9%	20.611	35,6%	13.943	43,7%	8.961	46,8%
Despesas de Selling	(10.123)	9,3%	(4.887)	8,4%	(3.277)	10,3%	(1.959)	10,2%
Contingência	(2.563)	2,4%	(1.362)	2,4%	(751)	2,4%	(451)	2,4%
Margem de Contribuição	30.828	28,3%	14.362	24,8%	9.915	31,0%	6.551	34,2%
IR e CSLL	(2.000)	1,8%	(1.063)	1,8%	(586)	1,8%	(352)	1,8%
Margem Líquida	28.828	26,4%	13.300	23,0%	9.329	29,2%	6.200	32,4%
Lucro Bruto REF Unit.	123.129	43,7%	104.634	39,8%	142.427	47,1%	159.368	49,8%
Lucro Raso REF Unit.	105.043	39,8%	93.936	37,3%	114.426	41,7%	131.463	45,0%

R$ Mil - VPL - Compra	Essence Butantã		HIS s/ Varanda		HMP c/ Varanda		R2V c/ Varanda	
	VP	%	VP	%	VP	%	VP	%
Receitas	62.071	100,0%	33.446	100,0%	17.826	100,0%	10.799	100,0%
PIS/COFINS	(1.341)	2,2%	(723)	2,2%	(385)	2,2%	(233)	2,2%
Custos e Despesas Totais	(48.322)	77,8%	(26.863)	80,3%	(13.618)	76,4%	(7.840)	72,6%
Custo Terreno	(5.531)	8,9%	(3.073)	9,2%	(1.544)	8,7%	(914)	8,5%
Custo Relacionados a Terreno	(1.692)	2,7%	(920)	2,8%	(486)	2,7%	(286)	2,6%
Custos de Incorporação	(1.051)	1,7%	(618)	1,8%	(278)	1,6%	(155)	1,4%
Custo de Construção	(31.538)	50,8%	(18.044)	53,9%	(8.636)	48,4%	(4.858)	45,0%
Despesas de Selling	(6.683)	10,8%	(3.230)	9,7%	(2.145)	12,0%	(1.308)	12,1%
Contingência	(730)	1,2%	(388)	1,2%	(214)	1,2%	(128)	1,2%
IR e CSLL	(1.097)	1,8%	(591)	1,8%	(315)	1,8%	(191)	1,8%
Lucro Imobiliário	12.408	20,0%	5.860	17,5%	3.823	21,4%	2.725	25,2%

Pareceres

Análise da Mancha e Implantação

Prospecção

Operações

Inteligência de Mercado

Financeiro

Anexos

- **DESCRIÇÃO DO IMÓVEL:** imóvel localizado na Cidade de São Paulo, Estado de São Paulo, na Av. Eng. Heitor Antônio Eiras Garcia, nº 1469, objeto da matrícula no 88.254 do 18º Cartório de Registro de Imóveis da Comarca de São Paulo/SP, inscrito na Prefeitura Municipal de São Paulo sob contribuinte nº 159.168.0001-1.

- **VENDEDORES:** Odete Simonassi Gatto, Terezinha Gatto De Camargo, Wilson Roberto De Camargo, Eduardo Gatto, Fernando José Gatto ("Interdito")

- **DA CONSULTA AO CADASTRO NACIONAL DE EMPRESAS INIDÔNEAS E SUSPENSAS (CEIS):** Consulta realizada em 09/12/2024, restando negativa para os Vendedores.

- **CONSIDERAÇÕES JURÍDICAS SOBRE O IMÓVEL:** Conforme Estudos Jurídicos e Estudo Técnico, datados respectivamente de 09/12/24 e 06/12/24, foram apontadas, em suma, as seguintes considerações: **(a) Retificação:** Conforme apontado no Relatório de Estudos Jurídicos apresentado, a descrição registrária do Imóvel não preenche os requisitos previstos no art. 176, §1º, inciso II, item "3" , letra "b", Lei nº 6.015/73, pois, apesar de haver encerramento de área, a indicação das medidas perimetrais e referência ao logradouro/localização e confrontações são precárias. Adicionalmente, a descrição do Imóvel na matrícula encerra área de 2.307,19m², divergente da tabular em 122,81m² que encerra 2.430,00m². Comparando-se a área física indicada pelo levantamento planialtimétrico de 2.471,33m², com a área registraria, o Imóvel possui divergência de 41,33m² maior fisicamente. Ao se verificar os elementos físicos e materializados, foi traçada uma poligonal física de 2.522,25m² que será a área final da retificação, sendo que a matrícula carece também de atualização de confrontações, tornando-se imprescindível promover a retificação com fulcro no Art. 213, inciso II, da Lei nº 6.015/73 para estes atos; **(b) Regularidade Ambiental:** Conforme certidões ambientais emitidas pela SVMA, bem como pela CETESB não foram localizados Autos de Multa, tampouco denúncias para o Imóvel, ressalvada a indicação de que o Imóvel é suspeito de contaminação, bem como que foi desenvolvida atividade de fabricação de plásticos no local, existindo no sistema da CETESB um processo já extinto cujo objeto é a obtenção de licença prévia para a atividade de fabricação de artefatos plásticos feitas pela empresa Eduardo Gatto – ME, assim sendo recomendamos nossa área técnica (LEG) verifique eventuais providencias que devam ser tomadas no terreno. **(c) Loteamento**: Foi identificado na cadeia filiatória do Imóvel na Transcrição 16.784 do 4º RGISP o Loteamento nº 21 de 03 de agosto de 1938, inscrito na vigência do Decreto Lei nº 58/1937. sendo que, juridicamente, inexistem limitações convencionais atingindo-o que possa impactar no empreendimento pretendido. **DD IMÓVEL**: **(a) Área Construída**: Barracão com área construída de 588,35m² em situação "regular" junto à PMSP e averbada na matrícula; **(b) Débitos Imobiliários e Multas**: Não há; **(c) Ônus e Gravames**: Não há; **(d) Ocupação:** Não há; **(e) TAC**: Não há; **(f) CONDEPHAAT e CONPRESP:** Certidões negativas; **g) IPHAN**: Certidão negativa; **h) Desapropriação e Melhoramentos**: Certidões negativas; **(i) Função Social da Propriedade**: Consulta negativa; e **(j) Contas de consumo**: Foram apresentadas no âmbito da DD, sendo que no recebimento da posse pela Tenda não deverá haver débitos.

- **PROVIDENCIAS NECESSÁRIAS PARA A LAVRATURA DA ESCRITURA DE COMPRA E VENDA: (i) Vendedor FERNANDO**: Pessoa natural interditada. Em 02/07/24 foi autorizado no processo de interdição renovação de alvará judicial anteriormente expedido e a venda da cota parte do imóvel de titularidade do Vendedor, por valor não inferior ao da avaliação de R$8.300.000,00, por 12 meses adicionais, com a observação expressa de que indispensável a comprovação do depósito judicial da parte do preço que couber à FERNANDO, ficando autorizado o abatimento proporcional de impostos, taxas, comissões e honorários e desde que satisfeitas as demais exigências legais. Em que pese a existência de alvará vigente até 02/07/2025, em razão do alto investimento que será realizado por V.Sas. visando superar as condições resolutivas elencadas no CVC, a renovação do alvará pelo prazo de 22 meses revela-se essencial para conferir a segurança jurídica necessária para a realização dos investimentos, garantindo que a autorização para a venda se estenderá pelo prazo necessário para a superação das condições resolutivas e até a data prevista para a outorga da EVC, ficando, ainda, reduzindo eventuais riscos de alteração do valor mínimo de avaliação acima, para eventual adequação às condições de mercado futuras. Em 04/12/2024 foi protocolizada pelos Proprietários nos autos do processo de interdição acima, petição requerendo o alvará nos moldes acima, de modo que, aguarda-se a apreciação do pedido pelo MP e pelo juízo competente. **(ii) Vendedor EDUARDO**: Declarou no CVC que convive em União Estável com SANDRA YUMIKO TAKAHASHI há 10 (dez) anos, declarando, sob as penas da lei, não existir escritura ou contrato formalizando a referida união estável, razão pela qual a Companheira assinou o CVC na qualidade de assistente. Inexistindo formalização, aplica-se automaticamente o regime de comunhão parcial de bens à união estável, o que implica compartilhamento de todo o patrimônio adquirido onerosamente durante a convivência familiar em igual proporção, sendo presumido o esforço comum dos companheiros na aquisição dos bens, salvo se estipulado em contrário em contratos ou escrituras. Portanto, uma vez que Eduardo adquiriu sua fração do imóvel por herança em 1996, antes da existência da união estável, trata-se de “bem particular”, o qual não se comunica com a Companheira, ainda que futuramente venha a ser formalizada a união estável, estabelecendo como regime de bens o da comunhão universal, dado que a aquisição ocorreu em momento anterior. No mais, segundo o entendimento majoritário adotado pelo STJ, a escolha do regime de comunhão de bens em uma união estável por contrato escrito produz efeitos ex nunc, e cláusulas que estabeleçam a retroatividade desses efeitos são inválidas. Por ocasião da lavratura da escritura de compra e venda a companheira deverá assinar na qualidade de assistente anuente, bem como declarar expressamente que: (i) convivem em união estável por prazo a ser especificado em tal ocasião; (ii) que o imóvel foi adquirido por herança antes do início da união estável, não se comunicando com a companheira, a qual reconhece não possuir qualquer direito sobre o Imóvel.

- **CONSIDERAÇÕES ACERCA DOS PROPRIETÁRIOS E DO ANTECESSOR:** Não foram identificados nas certidões expedidas em nome dos Proprietários e do Antecessor, quaisquer apontamentos cujo risco tenha sido classificado como possível de impactar a aquisição pretendida por Vossas Senhorias.

LEGALIZAÇÃO E DPP

- **ÁREA DE IMPLANTAÇÃO**
- O terreno é composto pela matrícula 88.254 do 18º CRI, em nome de pessoa física, que totaliza uma área escriturária de 2.430m² e uma área real de 2.471,33m²;
- Conforme estudos técnicos e jurídicos a área da poligonal retificada é **2. 522,25m²**, sendo, necessário seguir pelo inciso II.
- O cadastro do imóvel é Urbano.
- O cenário foi desenvolvido sobre a poligonal de retificação final de **2.522,25m²**
- Conforme Ficha Técnica, o viário em frente ao imóvel possui 13,7m.

- **DIRETRIZES URBANÍSTICAS**
- O terreno está inserido em ZEIS-3 conforme decreto 63.728/24:
  - C.A.: 4,00 para EHIS e EHMP, sem restrição de gabarito e TO 70% e PA 05.
  - Para a poligonal final definida de 2.522,25m², é necessário reserva de calçada para alargamento de 5m.
- Terreno não será parcelado;
- O estudo considera implantação de 1 condomínio, sendo:
  - C01: 1 torre x 16PP T+25 , com 409UH – CA 5,29 (foi utilizado o incentivo de 50% de C.A para HIS 1 - Totalizando 100 unidades HIS1 do excedente do CA máximo.)
  - Cenário considera vagas sendo uma (1) PNE e uma (1) Idoso;
  - Usos permitidos: EZEIS, EHIS e EHMP.

- **COMAER**
- Inexigibilidade nº: 9AD8CC87B6
  - Altura: 75,72m
  - Atitude do topo: 855,72m

➢ AVALIAÇÕES AMBIENTAIS

Arbóreo

- O laudo arbóreo utilizado para o AP foi a RV02:
  - Conforme informado em Ficha Técnica, o terreno **não** é considerado como Patrimônio Ambiental;
  - Não incide sobre o terreno APP;
  - Não incide sobre o terreno Fragmento Florestal;
  - Foram cadastrados 31 indivíduos arbóreos isolados, sendo: 18 exemplares são de origem nativa, 08 de origem exótica e 05 exemplares mortos ou cadastrados como "toco". Não foram identificadas espécies sob regime de proteção especial. Nenhum dos exemplares encontrados está na ameaçado de extinção;
  - Compensação ficará em 180 exemplares de origem nativa, 36 de origem exótica e 05 exemplares para compensar os mortos ou tocos, totalizando 221 indivíduos arbóreos. Destes, 19 serão plantio interno e 202 para deliberação.
  - **Foi considerado** no estudo ambiental o uso **R2v** para a compensação arbórea.

Contaminação (terreno contaminado)

- Segundo informação da Ficha Técnica, o terreno **é** classificado com **suspeita de contaminação**.
  - Investigação Preliminar:
    - Indicada a necessidade de prosseguimento dos Estudos Ambientais.
  - Investigação Confirmatória:
    - **Existe contaminação no solo** por TPH e hidrocarbonetos (compostos associados a combustíveis, óleos e graxas) em duas regiões do terreno e em baixa concentração. **Contaminação da água** por Chumbo, também em baixa concentração, **sendo possível a reanálise para descaracterizar**.
    - Consultor ambiental acredita que os custos de remediação poderão ser menores do que a estimativa inicial.
  - Previsão da Investigação Detalhada – **40 dias úteis** a partir da contratação.

LEGALIZAÇÃO E DPP

- **GRAPROHAB**
  - Para efeito de Cronograma foi considerado dispensa de análise em GRAPROHAB por conta do número de unidades habitacionais (inferior a 800UH);

- **ABASTECIMENTO SANITÁRIO**
  - **Novo cenário de AP, o número de UH passou de 358 para 409UH. Necessário revalidação da Diretriz de SABESP (Prazo de 60 dias);**
  - Diretrizes SABESP OOO-207/24 – CARTA 468/24 **para 358UH**
    - Rede de água: Interligação na rede de diâmetro Ø 200 mm, localizada à Avenida Engº Antônio Heitor Eiras Garcia;
    - Rede de esgoto: Na Avenida Engº Heitor Antônio Eiras Garcia, há uma rede coletora de esgotos com capacidade adequada para receber os efluentes gerados por este empreendimento, possibilitando a realização da ligação especial;

- **HIDROGRAFIA**
  - O laudo hidrográfico utilizado: 24.204.01-LAU-PE-001-MEM-IMPL-R00
    - O Imóvel não apresenta corpos d'água internos. Próximo ao terreno a existência do Córrego Água Podre canalizado.

- **DRENAGEM**
  - Lançamento da drenagem será por gravidade até os tanques de retardo e reuso com lançamento na sarjeta por bombas.
  - O estudo hidrológico informa que o empreendimento deverá ficar superior a cota 773,25. No AP, a implantação da torre está na cota 773,45.

- **CERTIDÃO DE DIRETRIZES HIDRÁULICAS**
  - Ainda não recebemos, o processo está com comunique-se em aberto.

CRONOGRAMA

MÊS	RESP	ETAPA	INÍCIO	FIM	PRAZO (dias)
	OK	PLANIALTIMÉTRICO	6/3/25	6/3/25	-
	OK	POLIGONAL			-
	OK	CHECKLIST DOCUMENTAÇÃO			-
	NOK	CADASTRAMENTO ARBÓREO			-
	NOK	S AMBIENTAIS (LAUDOS FINALIZADOS E ASSINADOS)			-
	NOK	DIRETRIZES SABESP			-
	PROSP	1º COMITÊ INVESTIMENTO (50%)	16/12/24	16/12/24	-
	PROSP	CERTIDÃO DIRETRIZES HIDRÁULICAS (PROJ)	1/11/24	1/3/25	120
	PROSP	2º COMITÊ DE INVESTIMENTO (50%)	28/3/25	28/3/25	-
	NEG	1ª REUNIÃO DE PASSAGEM	15/1/25	15/1/25	-
	NEG	2ª REUNIÃO DE PASSAGEM	17/4/25	24/4/25	7
	JUR	MATERIAL DE RETIFICAÇÃO	16/12/24	4/2/25	50
	JUR	RETIFICAÇÃO INCISO II	6/2/25	8/12/25	305
	DPP	REVISÃO AP	11/3/25	21/3/25	10
	GETEC	ENGENHARIA SIMULTÂNEA	24/4/25	8/6/25	45
	LINHA	EP - KIT LEGAL	15/6/25	13/10/25	120
	LINHA	ELABORAÇÃO PL	15/6/25	30/6/25	15
	PROSP	DIRETRIZES SABESP (ATUALIZAR PARA 409 UH)	4/4/25	3/6/25	60
	GETEC	ELABORAÇÃO PROJETO DE EXTENSÃO DE REDE	10/6/25	8/10/25	120
	GETEC	APROVAÇÃO PROJETO DE EXTENSÃO	15/10/25	12/2/26	120
	LEG	TÉRMINO DOS LAUDOS AMBIENTAIS	4/4/25	3/6/25	60
	LEG	CETESB (COM CONTAMINAÇÃO)	10/6/25	7/12/25	180
	LEG	ALVARÁ DE APROVAÇÃO E EXECUÇÃO *	7/7/25	7/7/26	365
	LEG	DISPENSA GRAPROHAB	8/5/26	7/6/26	30
	JUR	FINALIZAÇÃO DUE DILIGENCE	8/5/26	7/6/26	30
	JUR	ESCRITURA	27/7/26	26/8/26	30
	JUR	REGISTRO INCORPORAÇÃO	27/8/26	26/10/26	60
	CRD	CONTRATAÇÃO CEF	28/6/26	26/10/26	120
22	NEG	LANÇAMENTO	26/10/26	26/10/26	-

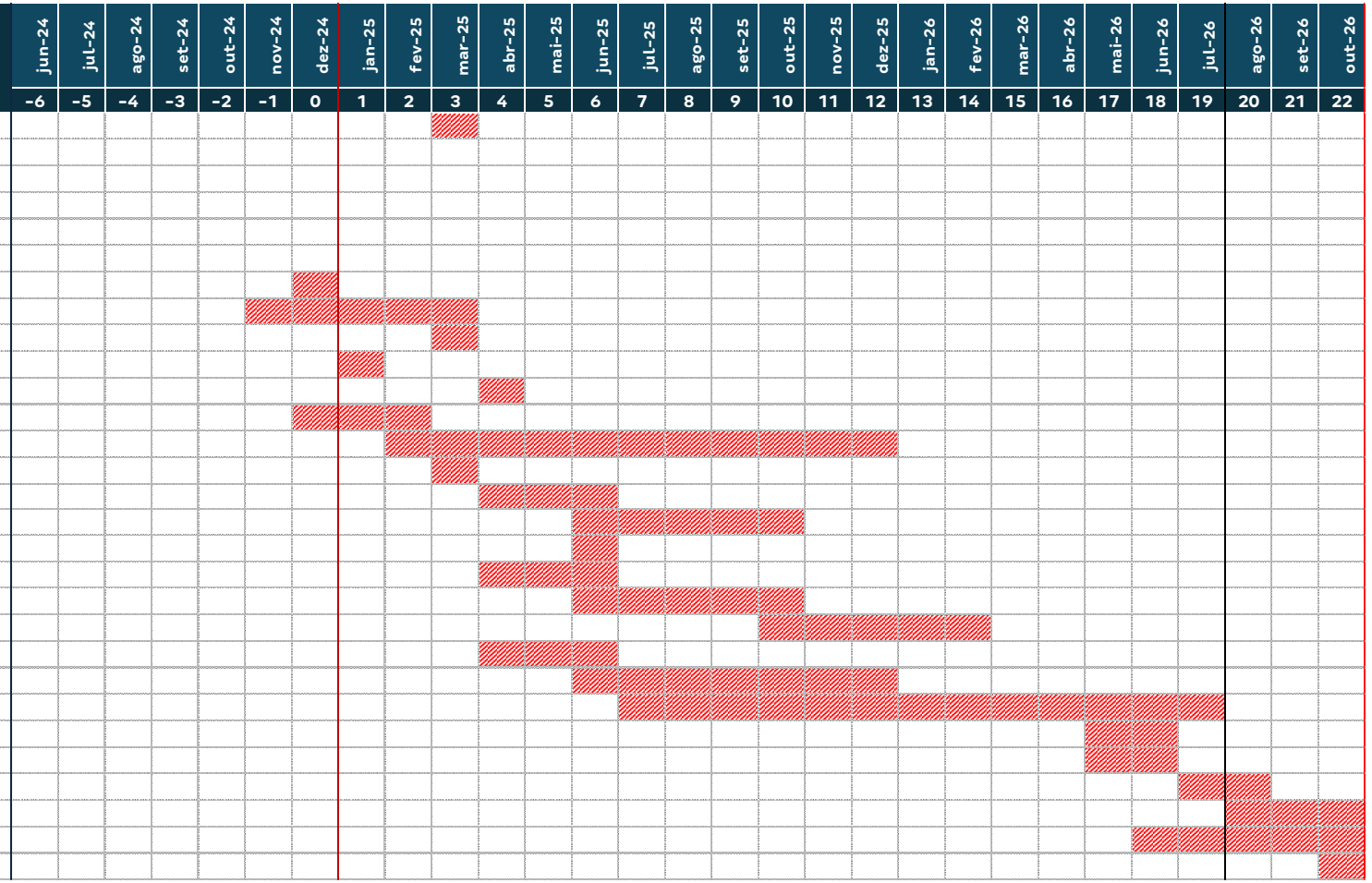

Obrigado