Tenda

sua próxima conquista

Book de Investimento

Regional: PR

Projeto: Raízes I e II (Savana)

Data Comitê: 09/06/2025

One Page – Raizes I e II

Cidade	Araucária	**Mancha de demanda**	PR - ARA - Araucária
Regional	PR	**Cluster MPR**	1 - Vermelho
Cenário de Aprovação	Aprovação	**Tipo de Aprovação**	Consolidado
Fase Anterior	N/A	**Aprovação Fase Anterior**	Consolidado
Tipo de Comitê	Investimento	**Versão da VF**	Versão 1.0: Jun

Unidades (% Vagas)	520 (105%)	**CA Máx | Proj**	1,0 | 0,4
Tipologia	F2 - Concreto	**Escritura**	mar-27
Fases	2 fases	**Lçto | Duração (m)**	jun/27 | 30

Valor Líquido do Terreno (% VGV)	11.996 (10,5%)	**Un. Perm. Fís (% Ter)**	0 (0,0%)
Cash (Correção)	0 (Não)	**%VGV Perm Fin Líquida (% Ter)**	10,5% (100,0%)
Valor R$/m²	369	**VAR (%VGV)**	000 (0,0%)

Custo Construção (%VGV)	53.037 (46,2%)	**Indireto Unit.**	18.130
Prazo da Obra (meses)	11	**Torre Unit.**	45.317
Custo Total Unit. (LPU):	101.995 (91)	**Infra Unit.**	27.011
Início de Obra	dez-27	**Fundação Unit.**	7.398

Preço Nominal Unit.	220.758	**VSO**	20
Preço Raso Unit.	199.514	**Referência**	-
Avaliação Unit.	225.538	**Renda (% em RET 1%)**	3.381 (40,8%)



LI (Régua):	**20,0% (20,0%)**	**Margem Bruta Econômica:**	36,9%
LI Resiliência:	14,7% (N/A)	**Margem Rasa Econômica:**	29,7%
Margem Bruta REF:	39,9%	**Margem Contribuição Econômica:**	25,5%
Margem Rasa REF:	**33,5%**	**Exposição (% VGV):**	8.949 (6,9%)
TIR:	190,2%	**VGV Total:**	114.794
Payback Contingente (21 m) :	**15 m/ (-6 m)**	**Ger. Caixa 12 meses (R$):**	-
Payback Consolidado:	15	**Ger. Caixa 24 meses (R$):**	(679)

Destaques

Terreno localizado no bairro Boqueirão, Araucária, totalizando 512 uhs distribuídas em 2 condomínios, próximo ao centro e com fácil acesso aos principais eixos viários que cortam o município. Bem atendido quanto a serviços públicos, comércios, supermercado, transporte publico e infra estrutura consolidada no entorno.

CVC assinado em 20/03/25.

CONDIÇÃO COMERCIAL

- **Total do contrato:** 11,44 MM, sendo **100% em permuta financeira** e referente a uma fração de **11% do VGV**. Aplicação de **descontos de 5%** referente a despesas de comercialização das uhs. **Preço Mínimo Garantido (PMG): 9,724MM. Preço VF: 12.627.383,00.**

CONDIÇÕES CONTRATUAIS

- **Escritura:** lavratura independentes dos imóveis 1 e 2 oriundos de subdivisão, e desde que cumpridas as resolutivas para cada empreendimento;
- **Principais Resolutivas:** padrão, com *way-out* por inviabilidade técnica/financeira.
- **Quanto ao PMG:** caso o preço mínimo de cada empreendimento não seja atingido em até 12 meses da emissão do habite-se, fica facultado aos permutantes:1) Receber o saldo da Tenda em parcela única, ficando extinta a divida ou;2) Aguardar o término dos pagtos e comercialização das uhs em estoque, ficando extinta a obrigação do PMG. **Não há atualização do PMG.**

PRAZOS CONTRATUAIS:

- Superação das resolutivas e escritura do imóvel 1: 24 meses da assinatura do CVC, prorrogáveis de comum acordo;
- Escritura do imóvel 2: em até 18 meses do lançamento comercial do condomínio 1, e desde que comercializadas 80% das uhs;
- Lçto Cond. 1 e 2: até 6 meses da escritura do respectivo imóvel;
- Início de obra : até 9 meses do lançamento de cada condomínio, com 180 dias de tolerância;
- Conclusão da Obra (habite-se): 36 meses do Registro de Incorporação de cada condomínio, com 180 dias de tolerância;
- Quitação do PMG: até 12 meses do habite-se de cada condomínio;
- O descumprimento dos prazos poderão gerar multa e rescisão.

GARANTIAS:

- Aos Permutantes: confissão de dívida e aval Construtora Tenda;
- Intermediação: não há.

DEMAIS CONSIDERAÇÕES:

- Produto contará com 37% das unidades com varanda e 105% de vagas (exigência legislação);
- Ciclo entende ser adequado o preço sugerido por IM para a renda e região, frente a concorrência. **Não considerado cheque estadual CASAFÀCIL/COHAPAR de 20k**.
- **PDAs para redução de custo:** realização de novas campanhas de sondagem para alteração da solução de fundação (-3k/uh) e revisão da LPU de terraplanagem.

- Pareceres
- Análise da Mancha e Implantação
- Prospecção
- Operações
- Inteligência de Mercado
- Financeiro
- Pareceres anexos

Farol Pareceres – Raízes I e II

Área	Riscos Associados	Parecer	Flag
Jurídico Imobiliário	Due diligence em andamento. Previsão de conclusão em 20/06/25.	Ok com ressalvas	
LEG	Necessidade de visto do DNIT para aprovação do projeto (etapa adicional na esteira de legalização). Licenciamento Ambiental via IAT (processo moroso)	Ok	
DPP	N/A	Ok	
Inteligencia de Mercado	IM avalia o Preço Vision como factível	Ok	
Comercial/Ciclo	Ciclo entende ser adequado o preço sugerido por IM para a renda e região frente a concorrencia. Não considerado cheque estadual Casa Fácil/COHAPAR de 20 k.	Ok	
GETEC	Sem Riscos	Ok	
Logistica	Sem Riscos	Ok	
Contratação	Sem Riscos	Ok	
Estudos Economicos	Sem riscos.	Ok	

Pareceres

Análise da Mancha e Implantação

Prospecção

Operações

Inteligência de Mercado

Financeiro

Pareceres anexos

Mancha de Demanda

MANCHAS DE DEMANDA

- ARA – Araucária

LandBank
1. Gran Costeira/Torino
2. Raizes I

Cluster MPR – (Comitê)

- Cluster 1 - Vermelho

Região

Metropolitana

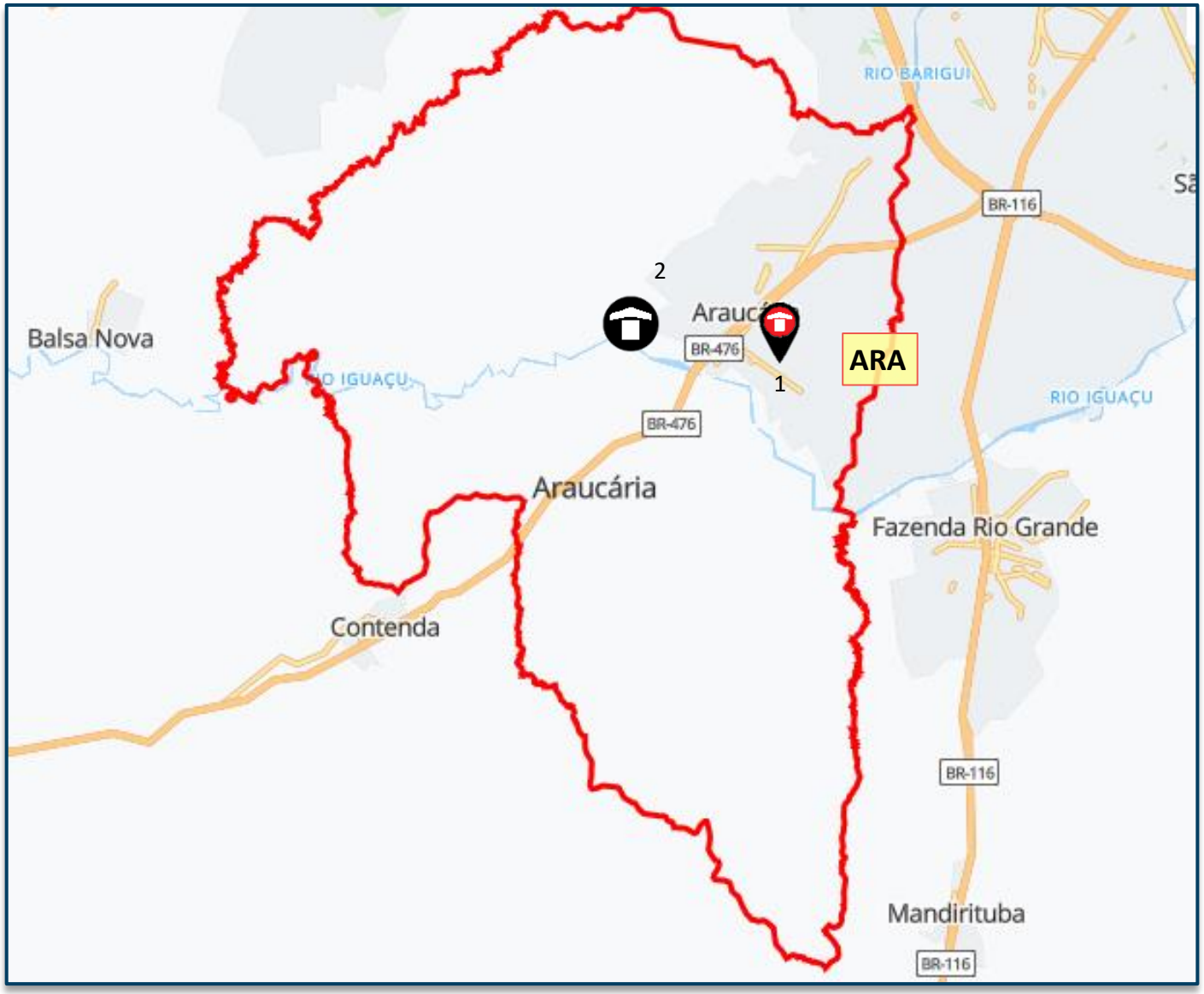

Lançados *LandBank* *Comitê*

PRODUTO

Empreendimento Raízes I e II
Investimento

Informações Gerais – Todos os Condomínios		
Terreno	**Área terreno**	51.603,12m²
	Menor poligonal	51.603,12m²
	Área Verde Urbana/FNA	Sim/Sim
	Reserva de calçada/ Atingimento Viário	Não/Sim
	Área liquida	34.241,35m²
	Zoneamento	Zona Residencial 2 – ZR2 (por espelhamento)
	Ca Básico	1,50
	Ca projetado	0,51
	Densidade Máxima por condomínio	260UH
	Gabarito máximo	T+11
Geral	**Total uh**	520
	Total de vagas	548

LEGENDA:

01 Área Verde Urbana

02 FNA - Rodovia

03 Doação

IMPLANTAÇÃO

PRODUTO

Empreendimento Raízes I
Investimento

Informações Gerais – Condomínio 01		
Terreno	Área terreno real	27.703,69 m²
	Área Verde Urbana (AVU)	10.332.97 m²
	Área liquida	17.370,72 m²
	Zoneamento	Zona Residencial 2 – ZR2 (por espelhamento)
	Ca Básico	1,50
	Ca projetado	0,37
	Gabarito máximo	T+11
Geral	Total uh	260
	Total de vagas	Automóveis: 105% (274) Moto: 7%(18)
Tipologia	Tipologia	PR-0201-LF-PC10
	Gabarito	T+3
	Lâmina	3X 16PP-CS1B 1X 18PP-CS1B
	Área privativa	34,99m²
	Varandas	37% (96 UH)- exceto térreo
Condomínio	Unidade pcd	08 (térreo)
	Unidade lazer	04
	Torres	04
	Fases	ÚNICA
Lazer	Lazer coberto	Salão de Festas c/ Churrasqueira, Churrasqueira Gourmet Brinquedoteca/ Espaço Office/ Espaço Teen/ Fitness interno
	Lazer descoberto	Praça de Chegada/ Quadra/ Play Baby/ Play Kids/Play Pet/Funcional/ Fitness Externo/ Praça dos Sabores/ Praça de Jogos/Espaço Cultivo/Espaço Relax

LEGENDA:

- 01 Portaria com pórtico
- 02 Área Verde Urbana
- 03 Área Técnica
- 04 Área de Lazer
- 05 Torres com varanda
- 06 FNA - Ferrovia

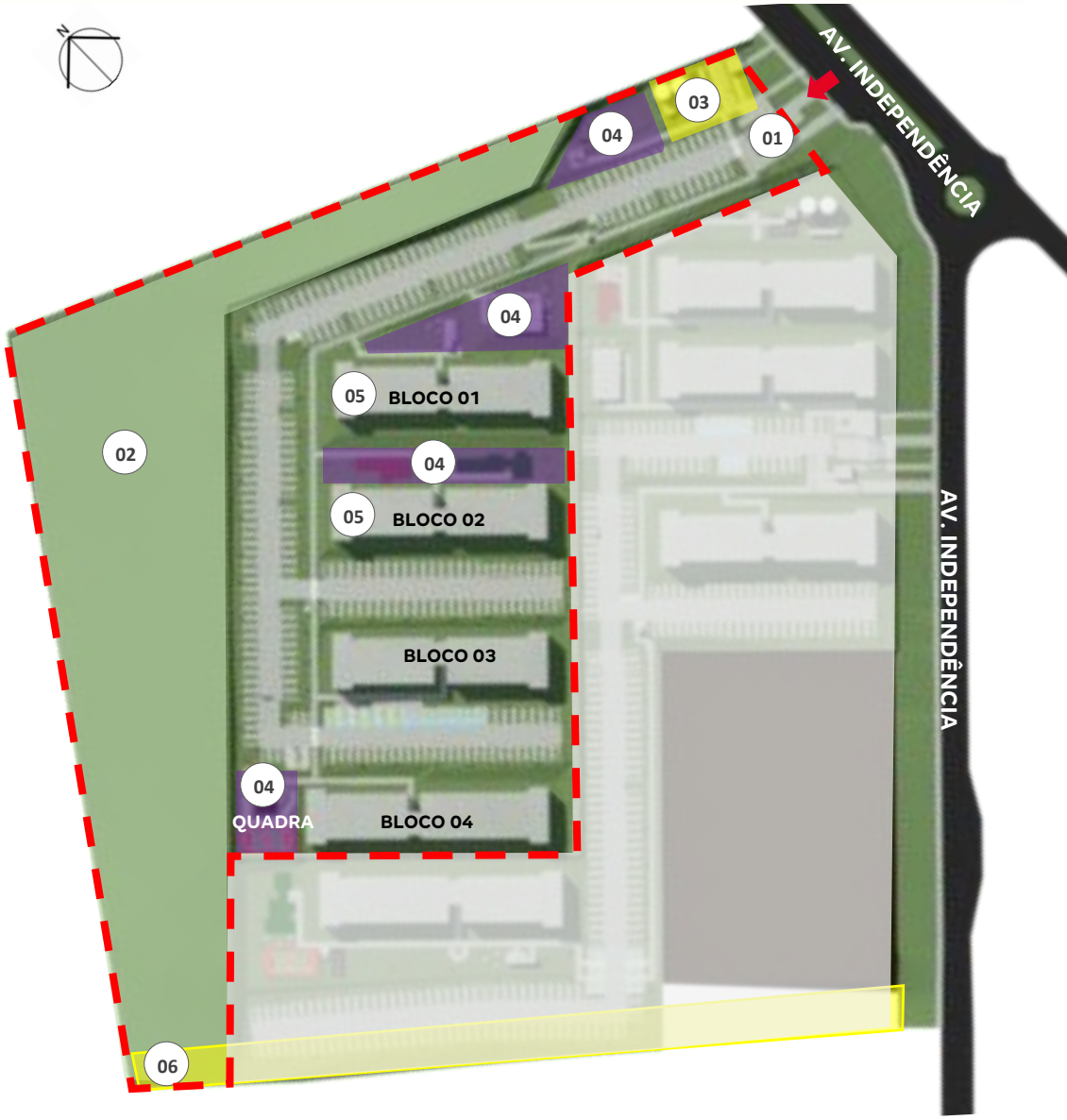

IMPLANTAÇÃO

PRODUTO

Empreendimento Raízes II
Investimento

Informações Gerais – Condomínio 02		
Terreno	Área terreno real	16.870,64 m²
	Área Verde Urbana (AVU)	-
	Área liquida	16.870,64m²
	Zoneamento	Zona Residencial 2 – ZR2 (por espelhamento)
	Ca Básico	1,50
	Ca projetado	0,62
	Gabarito máximo	T+11
Geral	Total uh	260
	Total de vagas	Automóveis: 105% (274) Moto: 9%(25)
Tipologia	Tipologia	PR-0201-LF-PC10
	Gabarito	T+3
	Lâmina	3X 16PP-CS1B 1X 18PP-CS1B
	Área privativa	34,99m²
	Varandas	37% (96 UH)- exceto térreo
Condomínio	Unidade pcd	08 (térreo)
	Unidade lazer	04
	Torres	04
	Fases	ÚNICA
Lazer	Lazer coberto	Salão de Festas c/ Churrasqueira, Churrasqueira Gourmet Brinquedoteca/ Espaço Office/ Espaço Teen/ Fitness interno
	Lazer descoberto	Praça de Chegada/ Quadra/ Play Baby/ Play Kids/Play Pet/Funcional/ Fitness Externo/ Praça dos Sabores/ Praça de Jogos/Espaço Cultivo/Espaço Relax

LEGENDA:

- 01 Portaria com pórtico
- 02 Área Verde Urbana
- 03 Área Técnica
- 04 Área de Lazer
- 05 Torres com varanda
- 06 FNA – Ferrovia

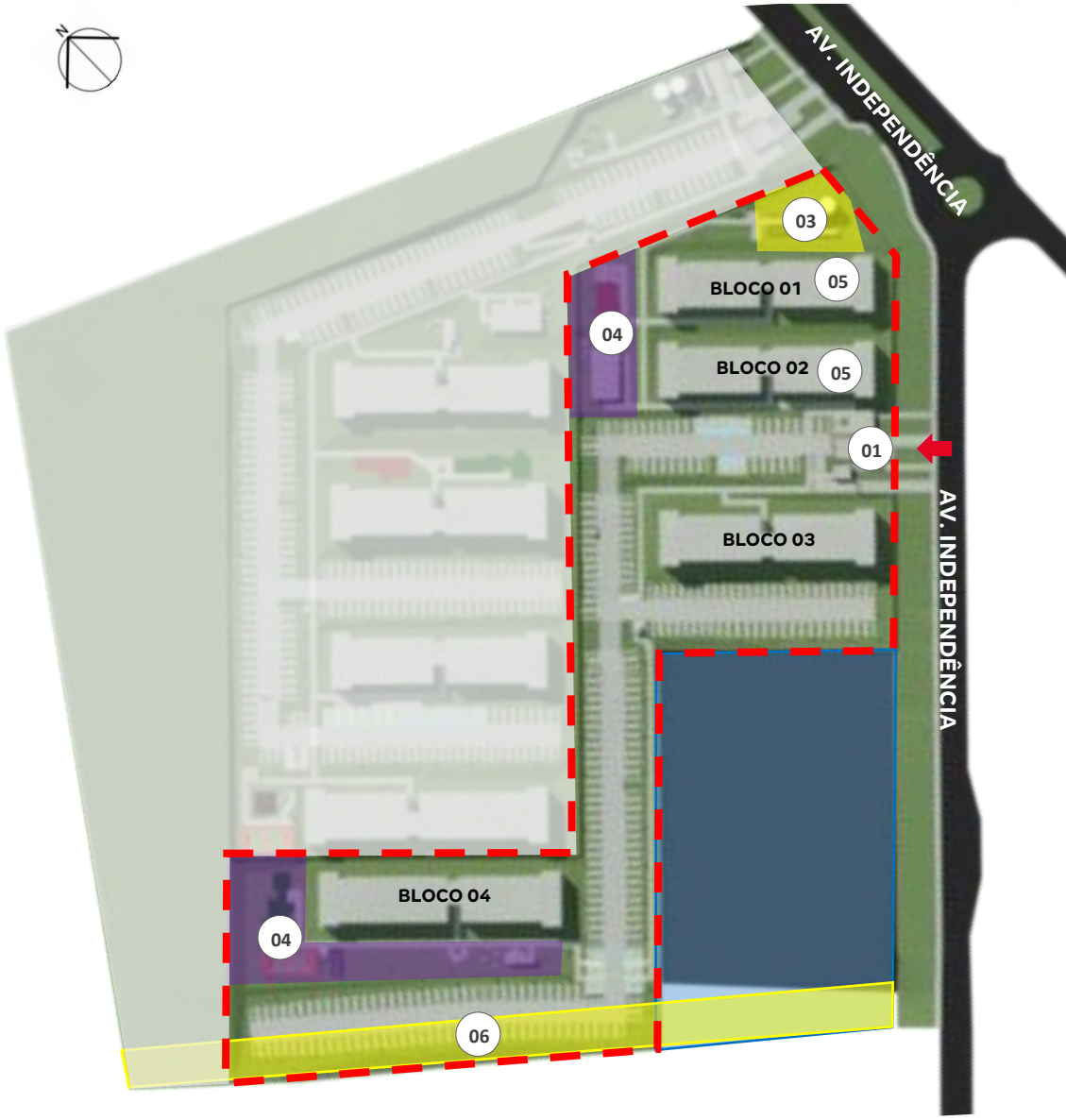

IMPLANTAÇÃO

PRODUTO

Empreendimento Raízes I e II
Investimento

	Descrição	Criticidade	Parecer
Usabilidade	**Limite supercondomínio**		-
	Acesso		Elevador PCD
	Percurso do pedestre até torre		Percurso de 300m para chegar nas últimas torres
Diferencial produto	**Atributos Infra**	Sim	Portaria com Pórtico e Quadra Poliesportiva
	Atributos Torre	Sim	Varanda
	Edifício Garagem	Não	-



CONDOMINIO 01 – **PORTARIA**



CONDOMINIO 01 - **QUADRA**



CONDOMINIO 02 – **PORTARIA**

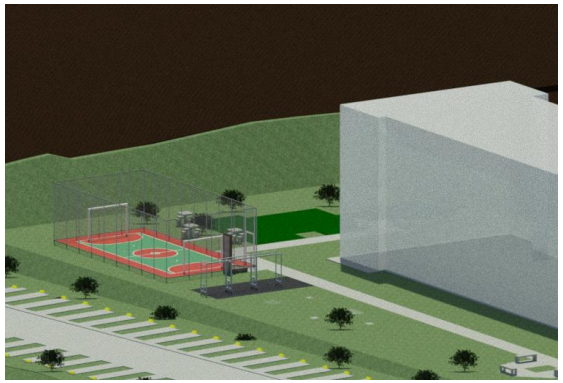

CONDOMINIO 02 - **QUADRA**

VISTA 3D – **CONDOMINIOS**

Pareceres

Análise da Mancha e Implantação

Prospecção

Operações

Inteligência de Mercado

Financeiro

Pareceres anexos

Condições do Negócio

VALOR DO NEGÓCIO

- **Valor Total: R$ 11.440.000,00.** Na VF: 12,6MM (diferença entre preço de venda entre estimado CVC = 200k e parecer IM = 220k);

➢ **FORMA DE PAGAMENTO**

- **Permuta financeira de 11 % do VGV, com Preço Mínimo Garantido de R$ 9.724.000,00 e aplicação de descontos de 5%. Não há correção do PMG;**
- Os pagamentos mensais em permuta serão realizados conforme disposição contratual padrão, ou seja, do decurso do prazo de 6 meses do lançamento das vendas e desde que superado o prazo legal de carência da Incorporação, limitado a 180 dias. Demais pagamentos ocorrerão no mesmo dia dos meses subsequentes ao 1° pagamento.

➢ **CONDIÇÕES DO NEGÓCIO**

- **Escritura:** lavratura independentes dos imóveis 1 e 2 oriundos de subdivisão, e desde que cumpridas as resolutivas para cada empreendimento;
- **Principais Resolutivas:** padrão, com *way-out* por inviabilidade técnica/financeira;
- **Quanto ao PMG:** caso o preço mínimo de cada empreendimento não seja atingido em até 12 meses da emissão do habite-se, fica facultado aos permutantes:1) Receber o saldo da Tenda em parcela única, ficando extinta a divida ou;2) Aguardar o término dos pagtos e comercialização das uhs em estoque, ficando extinta a obrigação do PMG.

➢ **PRAZOS CONTRATUAIS**

- Superação das condições resolutivas e escritura: Para o imóvel 1, 24 meses da assinatura da CVC, prorrogáveis de comum acordo. Para o imóvel 2, em até 18 meses do lançamento comercial do empreendimento 1 e desde que comercializadas 80% das uhs do mesmo;
- Lançamento Condomínio 1 e 2: em até 6 meses da referida escritura;
- Início de Obra Condomínio 1: até 9 meses do lançamento de cada condomínio, com 180 dias de tolerância;
- Conclusão das Obras com emissão do Habite-se: até 36 meses do lançamento de cada condomínio, com 180 dias de tolerância;
- Quitação do Preço Mínimo Garantido: em até 12 meses da emissão do habite-se do referido condomínio;
- O atraso nos pagamentos e/ou lançamentos estarão sujeitos às penalidades contratuais.

➢ **GARANTIAS**

- **Em favor da Tenda:** N/A, pagamentos após escritura;
- **Em favor das Permutantes:** Confissão de Dívida e Aval Construtora Tenda SA.

➢ **CORREÇÃO MONETÁRIA**

- NA

➢ **INTERMEDIAÇÃO IMOBILIÁRIA**

- NA

➢ **Demais Considerações**

- Mantidas todas as condições resolutivas padrão Tenda no CVC;
- CVC assinado pelas permutantes em **20/03/25.**

Pareceres

Análise da Mancha e Implantação

Prospecção

Operações

Inteligência de Mercado

Financeiro

Pareceres anexos

Custo de Construção

	COND 1 RAÍZES I CEN01 | REV00	COND 2 RAÍZES II CEN01 | REV00	CONSOLIDADO RAÍZES (SAVANA) CEN 01 | REV00	ELEVATO MIRAGGIO ATIVO NT CEN02 | REV03
Torres	4	4	8	2
Unidades Construídas	264	264	264 | 264	408
Unidades Vendidas	260	260	260 | 260	400
Unidades Varada	96	96	96 | 96	285
Condomínios (qta.)	1	1	2	1
Cidade	Araucária - PR	Araucária - PR	Araucária - PR	Curitiba - PR
Produto / Selo	F2 MODULAR	F2 MODULAR	F2 MODULAR	F2E MODULAR
Tipologia	3 Torres | T+03 | 16PP | CS1B	3 Torres | T+03 | 16PP | CS1B	6 Torres | T+03 | 16PP | CS1B	1 Torre | T+16| 10PP | CE1A
Tipologia	1 Torre | T+03 | 18PP | CS1B	1 Torre | T+03 | 18PP | CS1B	2 Torres | T+03 | 18PP | CS1B	1 Torre | T+16| 14PP | CE1A
Projeto Infra	AP	AP	AP	AP
Projeto Torre	AP	AP	AP	AP
Mês Base	junho-25	junho-25	junho-25	março-25
Incc	1.191,327	1.191,327	1.191,327	1.173,775
LVS	abril-25	abril-25	abril-25	janeiro-25
Indiretos	abril-25	abril-25	abril-25	janeiro-25
Base de Preço	LPU 91	LPU 91	LPU 91	LPU 86
Takt	2x2	2x2	2x2	2x2
Prazo (mês)	11	11	11 | 11	18
CUSTO TOTAL I	R$ / UND R$ 102.617	R$ / UND R$ 101.373	R$ / UND R$ 101.995	R$ / UND R$ 97.070
Indireto	R$ 18.351	R$ 17.909	R$ 18.130	R$ 18.800
Torre	R$ 45.317	R$ 45.317	R$ 45.317	R$ 56.221
Infra	R$ 27.356	R$ 26.666	R$ 27.011	R$ 15.878
Fundação	R$ 7.412	R$ 7.384	R$ 7.398	R$ 4.690
EEE				
ETE				
Contenção	R$ 392	R$ 181	R$ 286	R$ 777
Terraplenagem	R$ 3.788	R$ 3.916	R$ 3.852	R$ 704
CUSTO TOTAL II				
Urbanização				
Drenagem				
Extensão de Rede Elétrica				
Extensão de Rede Hidráulica				
CUSTO TOTAL III				
Incorridos				
CUSTO TOTAL IV				
Aprendizado				
CUSTO TOTAL V				R$ 1.452
Atualização por INCC				R$ 1.452
CUSTO TOTAL I+II	R$ 102.617	R$ 101.373	R$ 101.995	R$ 97.070
CUSTO TOTAL I AO IV	R$ 102.617	R$ 101.373	R$ 101.995	R$ 98.521

Custo de Construção

	CONSOLIDADO RAÍZES (SAVANA) CEN 01 | REV00	ELEVATO MIRAGGIO ATIVO NT CEN02 | REV03	
Torres	8	2	
Unidades Construídas	264 | 264	408	
Unidades Vendidas	260 | 260	400	
Total Unidades Vendidas	520	475	
Unidades Varada	96 | 96	285	
Condomínios (qta.)	2	1	
Cidade	Araucária - PR	Curitiba - PR	
Produto / Selo	F2 MODULAR	F2E MODULAR	
Tipologia	6 Torres | T+03 | 16PP | CS1B	1 Torre | T+16| 10PP | CE1A	
Tipologia	2 Torres | T+03 | 18PP | CS1B		
Projeto Infra	AP	AP	
Projeto Torre	AP	AP	
Mês Base	junho-25	março-25	
Incc	1191,327	1173,775	
LVS	abril-25	janeiro-25	
Indiretos	abril-25	janeiro-25	
Base de Preço	LPU 91	LPU 86	
Takt	2x2	2x2	
Prazo (mês)	11 | 11	18	
CUSTO TOTAL I	R$ / UND R$ 101.995	R$ / UND R$ 97.070	DIF R$ 4.925
Indireto	R$ 18.130	R$ 18.800	-R$ 669
Torre	R$ 45.317	R$ 56.221	-R$ 10.904
Infra	R$ 27.011	R$ 15.878	R$ 11.133
Fundação	R$ 7.398	R$ 4.690	R$ 2.708
EEE	R$ 0	R$ 0	R$ 0
ETE	R$ 0	R$ 0	R$ 0
Contenção	R$ 286	R$ 777	-R$ 491
Terrapplenagem	R$ 3.852	R$ 704	R$ 3.148
CUSTO TOTAL II	R$ 0	R$ 0	R$ 0
Urbanização e Galeria	R$ 0	R$ 0	R$ 0
Drenagem	R$ 0	R$ 0	R$ 0
Extensão de Rede Eletrica	R$ 0	R$ 0	R$ 0
Extensão de Rede Hidráulica	R$ 0	R$ 0	R$ 0
CUSTO TOTAL III	R$ 0	R$ 0	R$ 0
Incorridos	R$ 0	R$ 0	R$ 0
CUSTO TOTAL IV	R$ 0	R$ 0	R$ 0
Aprendizado	R$ 0	R$ 0	R$ 0
CUSTO TOTAL V	R$ 0	R$ 1.452	-R$ 1.452
Atualização por INCC	R$ 0	R$ 1.452	-R$ 1.452
CUSTO TOTAL	R$ 101.995	R$ 98.521	R$ 3.474

INDIRETOS

+693 | G11 – Serviços Técnicos (Diluição)
-239 | G13 – Pessoal Permanente (R13 x R12 – Redução salarial)
+212 | G14 – Administração (Diluição)
+771 | G15 – Canteiro (Diluição | Preço | Maior quantidade de tapume)
-860 | G16 – SSO (Ausência de SLQA)
-1.638 | G17 – Equipamentos (F2: Skytrack x F2E: Mini grua + Cremalheira)
+585 | G18 – Ensaios (Diluição do ensaio para estaca)

TORRE

-2.2.443 | Instalações (LVS F2 x F2E)
-2.287 | Vertical (LVS F2 Abr/25 x F2E Jan/25)
+251 | Forma (Retroalimentação Abril x Janeiro)
-339 | Aço (Projeto F2xF2E)
-1.348 | Concreto
Projeto (Raízes F2: 11,30m³/uh x Miraggio F2E: 12,84m³/uh)
Preço (Raízes: R$562,92/m³ x Miraggio: R$582,41/m³)
+1.088 | Telhado (Diluição)
-429 | Outros revestimento de parede (Ausência do poço do elevador)
-251 | Esquadria de Ferro (Ausência de Porta Corta Fogo)
+928 | Ventilação mecânica (Projeto)
-6.448 | Elevador (Projeto)

INFRA

+4.546 | Outros Revestimentos de Piso (Raízes 100% vaga x Miraggio 13% vaga)
+1.616 | Instalações (LVS F2 Abr/25 x LVS Média F2E Jan/25)
+1.300 | Anexos (Diluição/Projeto – Plataforma PNE)
+1.042 | Paisagismo (Diluição/Projeto – Raízes 7.373m² x Miraggio 5.096m²)
+842 | Enterrados (Diluição)
+787 | Esquadria de Ferro (Diluição)

FUNDAÇÃO

+2.708 | Projeto (Diluição/Projeto)
Raízes: EHC Ø30 – L=8m + radier com troca de solo de 1m
Miraggio: EHCØ50, 60 e 70cm – L=11~15m

TERRAPLENAGEM

+3.148 | Projeto/Diluição
Raízes: 20.274,77m³ de corte + 22.825,85m³ de aterro + raspagem de 40cm
Miraggio: Corte 3234,72m³, aterro 3973,43m³ + raspagem de 20cm

Operações

SISTEMA DE ABASTECIMENTO DE ÁGUA
Existe viabilidade técnica para abastecimento de água, ligação na Avenida Independência.

SISTEMA DE ESGOTAMENTO SANITÁRIO
Existe viabilidade técnica de esgoto, considerando extensão de rede do empreendimento até o ponto de ligação Avenida Independência.

SISTEMA DE DRENAGEM
Descarte para Avenida Independência.

SISTEMA DE ABASTECIMENTO DE GÁS
Abastecimento por GLP.

SISTEMA DE ABASTECIMENTO ELÉTRICO
Viabilidade emitida pela COPEL.

TERRENO

URBANIZAÇÃO
Considerado trecho de reconstituição da calçada na testada do terreno.

Operações

Matriz Risco Concessionária	
Água	Nível 3
Esgoto	Nível 3
Drenagem	NA
Elétrica	Nível 3
Gás	NA
Urbanização	NA

LEGENDA		
Nível	Tipo	Status
1	Com Diretriz	Conclusiva
2		Conclusiva com projeto aprovado
3		Conclusiva sem projeto aprovado
4		Não Conclusiva
5	Sem Diretriz	-
NA	-	Não aplicável

Água:
- Viabilidade emitida em 04/2025, com validade em 04/2026, ponto de tomada localizado na frente do empreendimento.

Esgoto:
- Viabilidade emitida em 04/2025, com validade em 04/2026, com extensão de rede do empreendimento até o ponto da Avenida Independência. Conforme artigo 57 da Resolução N°003 da Agepar, quando o ponto de entrega de água ou de coleta de esgoto estiver a uma distância máxima de 20 (vinte) metros das respectivas redes públicas e não houver a necessidade de reforço de capacidade, o prestador de serviços tomará a seu total encargo a expansão das redes de água e de esgoto. Desta forma, o custo não foi considerado no orçamento, conforme alinhamento com a regional.

Drenagem:
- Descarte para Avenida Independência.

Elétrica:
- Viabilidade emitida 03/2025.
- No pedido de ligação definitiva a concessionária pode vir a cobrar reformas necessárias, caso a infraestrutura existente não seja suficiente.

Gás:
- Empreendimento com GLP.

Urbanização:
- Considerado trecho de reconstituição da calçada na testada do terreno.

Logística

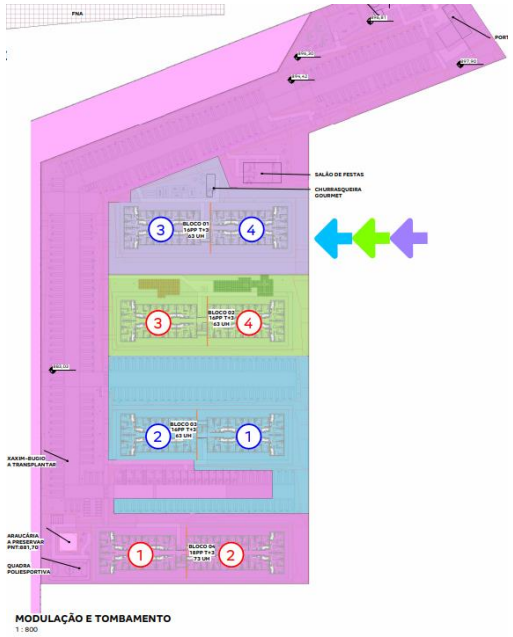
SALÃO DE FESTAS
CHURRASQUEIRA GOURMET
BLOCO 01 1dPP T+3 43 UN
BLOCO 02 1dPP T+3 43 UN
BLOCO 03 1dPP T+3 43 UN
BLOCO 04 1dPP T+3 73 UN
ARAUCÁRIA A PRESERVAR PNT.881,75
QUADRA POLIESPORTIVA
MODULAÇÃO E TOMBAMENTO
1 : 800

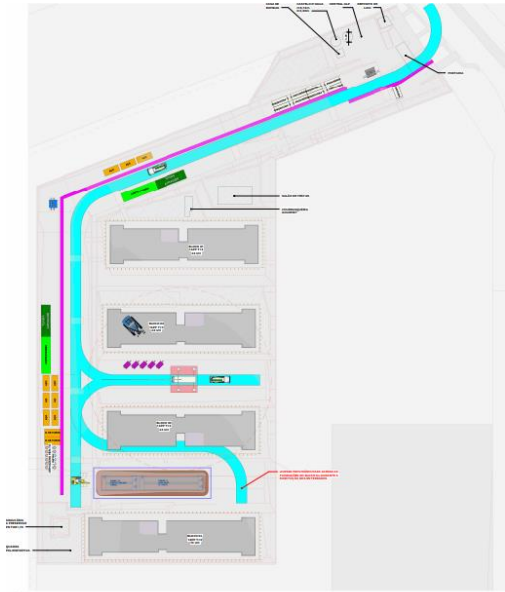
PRÉ FORMA

VISTA 3D - PRÉ FORMA

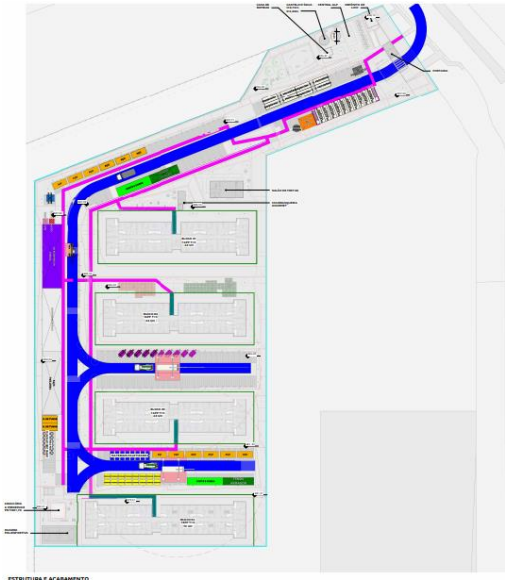

VISTA 3D - ESTRUTURA E ACABAMENTO

•CUSTOS / OBRA	**APOIO / BANHEIROS QUÍMICOS** CONSIDERAR EM CUSTO CONJUNTOS DE BANHEIRO QUÍMICO+BEBEDOURO+COBERTURA (CONFORME INDICADO EM PROJETO E TABELA QUANTITATIVA), DEVIDO AO DISTANCIAMENTO SUPERIOR À 100m DO POSTO DE TRABALHO DO COLABORADOR ATÉ A INSTALAÇÃO SANITÁRIA MAIS PRÓXIMA. PARA O BEBEDOURO, CONSIDERAR UMA TORNEIRA A CADA 25 COLABORADORES. **ENTERRADOS** PREVER CUSTO DE ESCADA PROVISÓRIA PARA ACESSAR A COTA DE FUNDO DOS ENTERRADOS E EXECUTAR A ESTRUTURA.

Logística

RAÍZES I (SAVANA) – COND.2

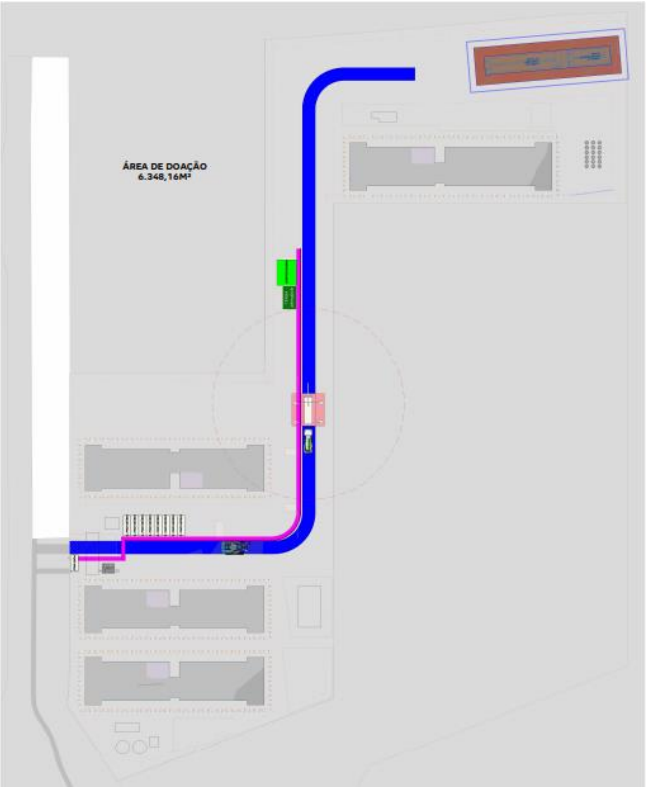

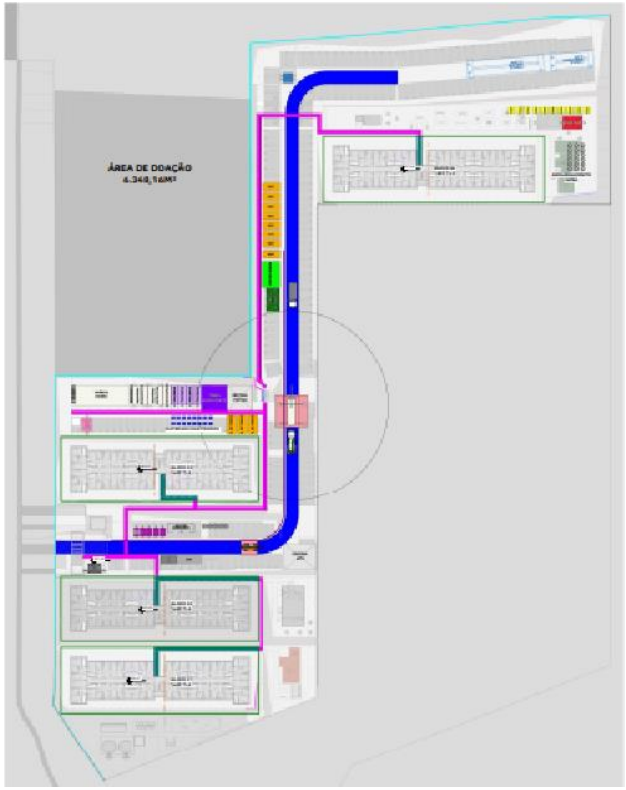

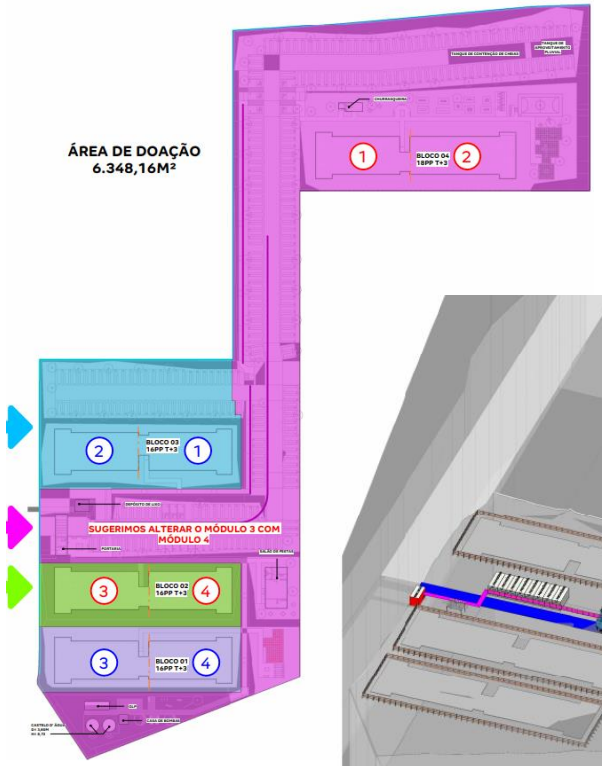

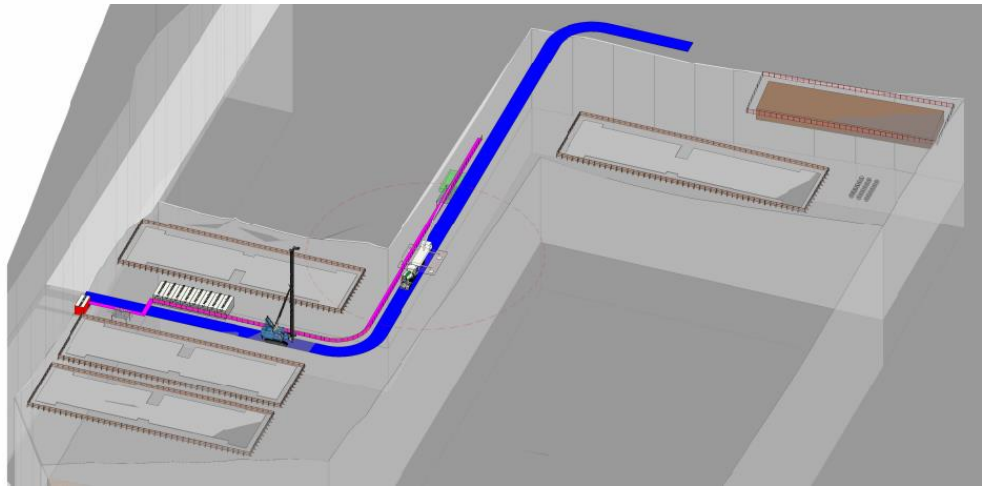

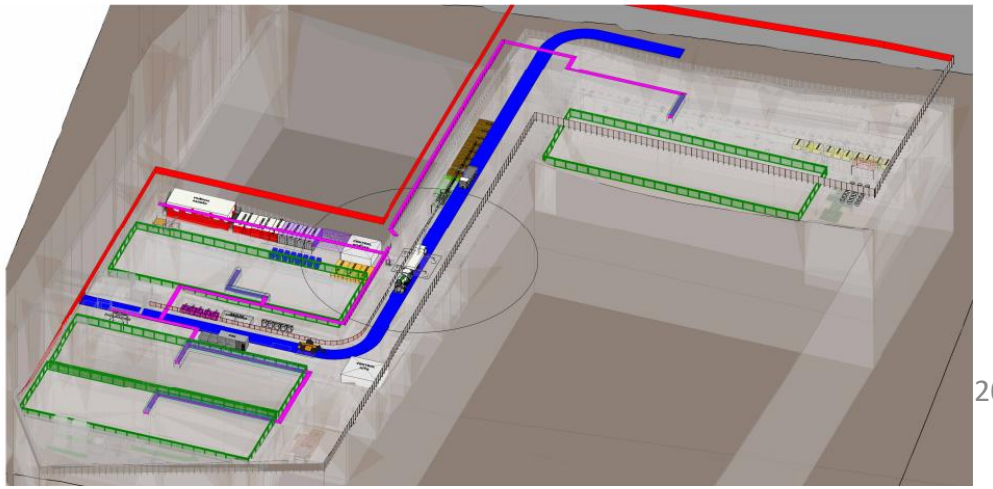

Pareceres

Análise da Mancha e Implantação

Prospecção

Operações

Inteligência de Mercado

Financeiro

Pareceres anexos

Mancha de Demanda

MANCHAS DE DEMANDA

- ARA – Araucária

LandBank
1. Gran Costeira/Torino
2. Raizes I

Cluster MPR – (Comitê)

- Cluster 1 - Vermelho

Região

Metropolitana

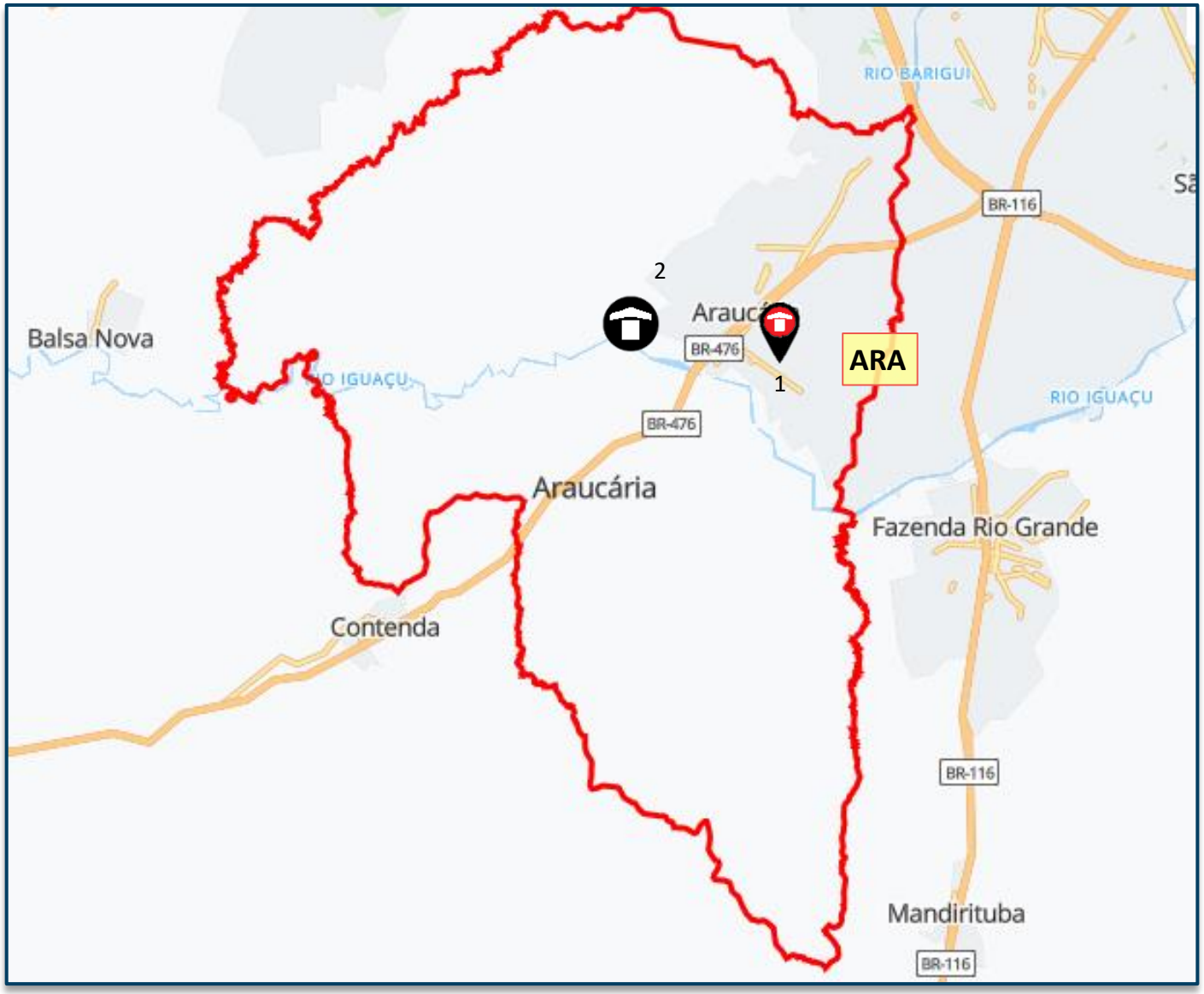

Lançados *LandBank* *Comitê*

Demanda e Distribuição da Mancha

Potencial de Demanda			Lançados		Lançados + Landbank	
Mancha	CÓD.	Shr.	ANO	MÊS	ANO	MÊS
Araucária	ARA	60%	356	30	428	36

Empreendimento	Renda	Lançamento	jul/27	ago/27	set/27	out/27	nov/27	dez/27	jan/28	fev/28	mar/28	abr/28	mai/28	jun/28	jul/28	ago/28	set/28	out/28	nov/28	dez/28	jan/29	fev/29	mar/29	abr/29
Raizes I	3.381	jul-27		20	20	20	20	20	20	20	20	20	20	20	20	20								
Raizes II	3.381	ago-28															20	20	20	20	20	20	20	20
Total de Vendas Lançados			0	0	0	0	0	0	0	0	0	0	0	0	0	0	0	0	0	0	0	0	0	0
Total de Vendas Lançados + Landbank			0	20	20	20	20	20	20	20	20	20	20	20	20	20	20	20	20	20	20	20	20	20

Parecer de I.M sobre a mancha:

O projeto analisado em comitê está em linha com o potencial teórico de demanda calculado para a mancha. (Total Lanç + Landbank)

Canibalização:

Sem Risco de Canibalização

Raizes I | Mapa Concorrência

		Raizes I	Magic Tower	Morada Ventura
		TENDA	Euro	Valor Real
	Distância Tenda (km)		2,9km	5,8km
Região 1 Km	População	6.176	9.209	8.627
	Dens. Demográfica	1.978	2.950	2.764
	Renda (R$)	4.879	5.810	4.732
	Classe Social	C1 (2.7k a 4.6k)	C1 (2.7k a 4.6k)	C1 (2.7k a 4.6k)
	PEA Dia	2.231	7.702	3.194
Quantitativo	Lançamento	jul/27	fev/25	09/2024
	Unidades	260	116	90
	Estoque	260	76	15
	VSO	20	13	25
	Stockout	13	6	1
	Preço Nominal (R$)	220.759	241.690	256.975
	Preço CEF (R$)	181.056	193.352	205.580
	Renda Comprador (R$)	3.381	4.100	4.850
	Dif Tenda (R$)		-814	-1.469
	Factibilidade		●	●
Qualitativo	Condomínios	2	1	1
	Torres	4	1	1
	Gabarito	T+3	T+8	T+8
	Plantas (m²)	35m²	44.75m²	42,27m²
	Tipologia	2 Dorms	2 Dorms	2 Dorms
	Opções	Não	Não	Garden
	Varanda	Sim	Sim	Sim
	Suite	Não	Não	Não
	Dif. Entrega	Não	-	-
	Vagas	100% de Vagas	100%	100%
	Lazer	Salão de festas, gourmet interno, fiitness interno, coworking, brinquedoteca, playkids, playbaby, playpet	Churrasqueira a Carvão, Sacada, Espaço Gourmet, Pet Place, Piscina, Playground, Quadra Poliesportiva, Salão de Festas.	Tem Garden, Academia ao ar livre, Bicicletário, Churrasqueria, Espaço Gourmet, Fitness Center, Playground,

Farol Renda
● Acima de 300
● Entre 0 e 300
● Abaixo de 0

Diagnóstico Concorrência

- A concorrência possui target de preço e renda acima ao previsto para o Raizes comparando as tipologias equivalentes.

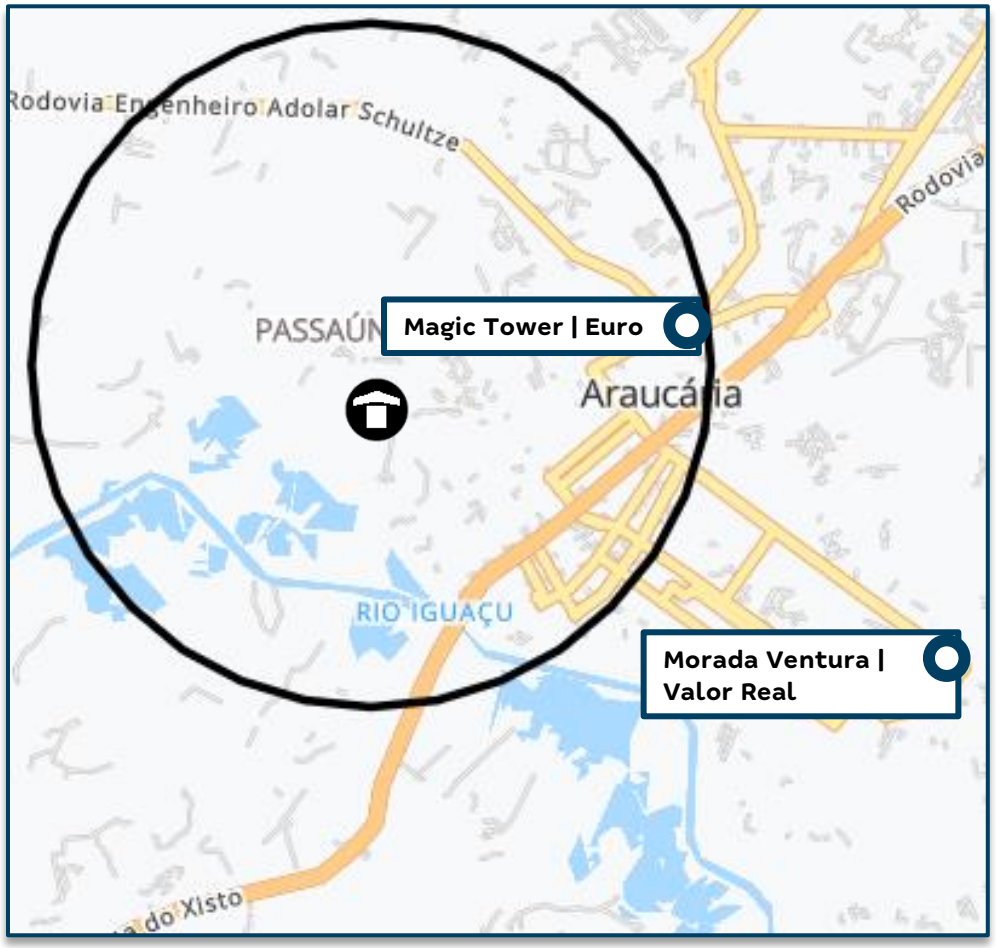

Simulação de Preço

Informações Viabilidade

Projeto:	Raizes I			
Tipo:	**Faixa 2**		**Faixa 2 - Varanda**	
Método	**Vision**		**Vision**	
Avaliação	220.000		235.000	
Renda Inicial (VF)	3.198		3.693	
Renda Final*	-		-	
% RET1	50%		25%	
Tipo:	**VF**	**R$**	**VF**	**R$**
Ato	0,52	1.666	0,56	2.073
FGTS	0,52	1.663	0,85	3.139
Financiamento	98,00%	168.095	100,27%	182.872
Subsídio	147,39%	6.328	197,08%	3.536
Prazo de Pró-soluto	16	16	16	16
Pró-Soluto	85,32%	15.862	85,32%	18.317
Preço Raso (RS)	193.614	193.614	209.937	209.937
TCD	71,11%	22.923	48,44%	18.032
VSO	13	13	7	7
Preço de Venda	**216.538**	**216.538**	**227.969**	**227.969**
Elasticidade	0,000%	0,000%	0,000%	0,000%
Preço de Venda Final	**216.538**	**216.538**	**227.969**	**227.969**
Preço Raso (R$)	**193.614**		**209.937**	
% de Raso	**89,41%**		**92,09%**	
BP25 - Não Inflacionado	**-**		**-**	
BP25 - Inflacionado	**-**		**-**	

Análise de Preço

Informações Viabilidade

Projeto:	Raizes I
Tipo:	**Faixa 2**
Método	Vision
Avaliação	225.538 (2)
Renda Inicial (VF)	3.381
Renda Final*	-

Tipo:	VF	R$
Ato	0,54	1.816
FGTS	0,64	2.208
Financiamento	98,84%	173.551
Subsídio	165,73%	5.297
Prazo de Pró-soluto	16	16
Pró-Soluto	85,32%	16.769
Preço Raso (RS)	199.641	199.641 (1)
TCD	62,74%	21.117
VSO	20	20
Preço de Venda	**220.759**	**220.759**
Elasticidade	0,000%	0,000%
Preço de Venda Final	**220.759**	**220.759**

Preço Raso (R$)	**199.641**
% de Raso	**90,43%**
Raso Todas as Fases	**199.641**
Nominal Todas as Fases	**220.759**

Análise de Riscos	Farol IM
IM avalia o Preço Vision como **factível**.	

1) I.M está de acordo com o preço Vision, tendo em vista que, o projeto está em uma região com bons indicadores sociodemográficos, como renda e PEA/Dia, o mesmo também se encontra próximo ao centro de Araucária com acessibilidade e pontos de interesse.
Conforme consta no slide "Panorama de Concorrência", os concorrentes da região vendem em um target de preço e renda acima do previsto para o Produto Tenda.
2) É fundamental que a avaliação seja mantida, a fim de garantirmos o preço estimado pelo Vision.

			Preço Real				Preço Normalizado (16m)	
	Gabarito	Avaliação	Preço Raso	Renda Média	VSO	PSOL	Δ PSOL	Preço Raso
Raízes I	T+3	225.538	199.641	3.381	20	16	-	199.641

Simulação de Preço – Fases Futuras

Vision

Nome Fase	Tipologia	Renda	Ato	FGTS	Cond.	Subsídio	PSOL	TCD	VSO	Nom. Pré	Avali.	Elast.	Nom. Pós	Raso Pós	PSOL (m)	RET1
Raizes II	Faixa 2	3.198	0,52	0,52	98,0%	147,4%	85,3%	71,1%	13	216.538	220.000	0,00%	216.538	193.614	16	50%
Raizes II	Faixa 2 - Varanda	3.693	0,56	0,85	100,3%	197,1%	85,3%	48,4%	7	227.969	235.000	0,00%	227.969	209.937	16	25%

ENTORNO

Distâncias - Mobilidade

- Av. Independência – em frente
- Av. Alfred Charvet – 1,1 km
- Terminal Central de Araucária – 2,3 km

Raio 2,5 Km

- Supermercado Super Massa
- Chácara Risotolândia
- Supermercado Primus
- Supermercado Condor Araucária

Parecer: Acreditamos que o preço é POSSÍVEL com o VSO proposto, dado a pouca concorrência direta.

CONCORRÊNCIA

Morada Ventura – Valor Real (Lançamento 2024)

- Preço Nominal: 278.497
- Avaliação: 234.189
- Renda: 4.732
- Estoque: 12 unidades
- Vagas: 100% de vagas
- Diferenciais: Garden, Academia ao ar livre, Bicicletário, Churrasqueira, Espaço Gourmet, Fitness Center e Playground

Magic Tower – Euro (Lançamento 2024)

- Preço Nominal: 241.690
- Avaliação: 193.352 (sem info quanto a atualização)
- Renda: 5.810
- Estoque: 76 unidades
- Vagas: 100% de vagas
- Diferenciais: Churrasqueira a Carvão, Sacada, Espaço Gourmet, Pet Place, Piscina, Playground, Quadra Poliesportiva, Salão de Festas.

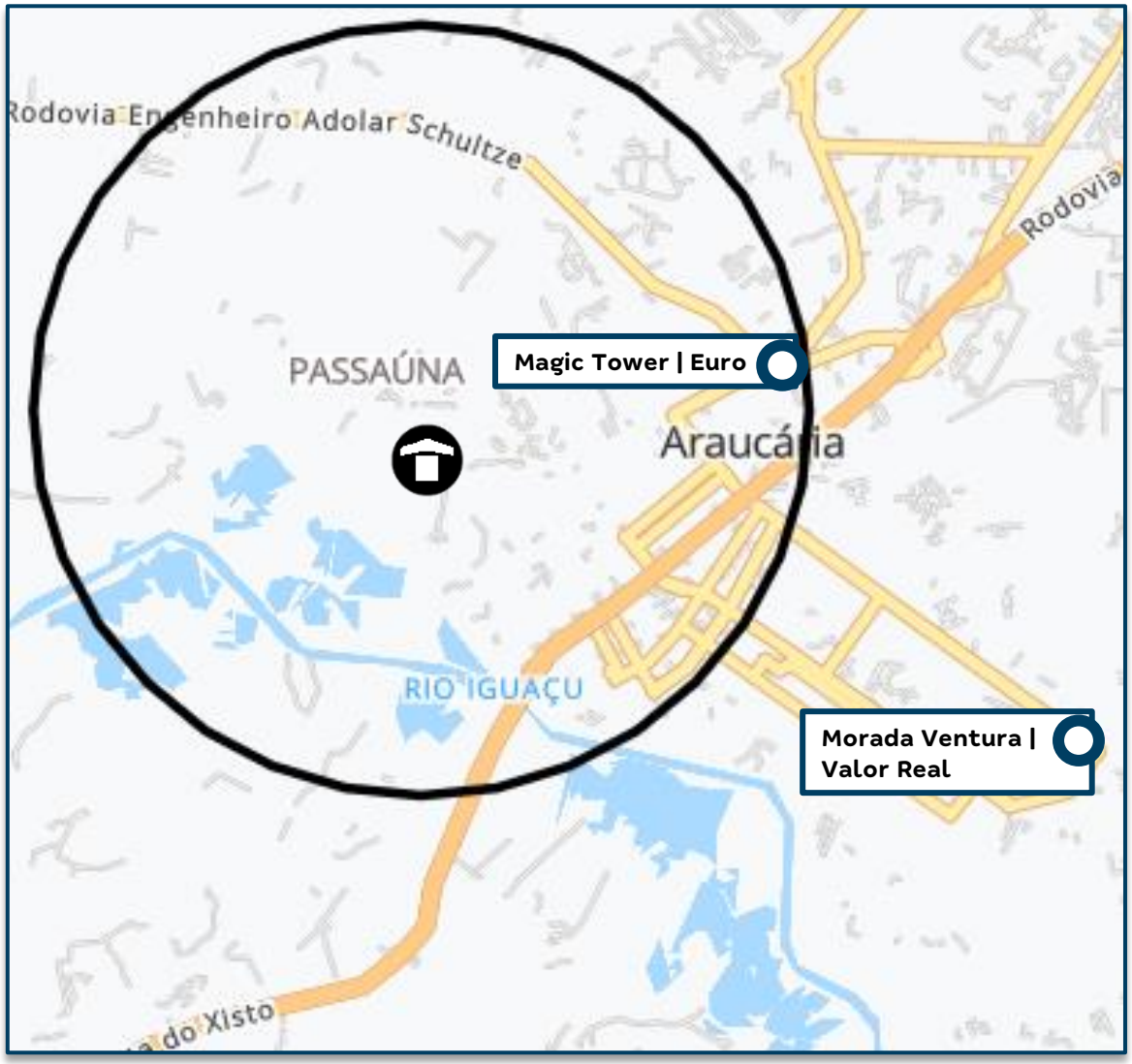

Pareceres

Análise da Mancha e Implantação

Prospecção

Operações

Inteligência de Mercado

Financeiro

Pareceres anexos

Resumo

Raízes I e II - PR - Região Metropolitana > 100mil PR

Datas e Prazos

	Compra	Lançamento	Início Obra	Término Obra	LÇTO até IO	IO até TO	Chaves	LÇTO até Chaves
Consolidado	mar-25							
Raízes I e II F1		jun-27	dez-27	nov-28	6 meses	11 meses	jun-30	36 meses
Raízes I e II F2		jun-27	dez-27	nov-28	6 meses	11 meses	jun-30	36 meses
Raízes I e II F3		jul-28	jan-29	dez-29	6 meses	11 meses	jul-31	36 meses
Raízes I e II F4		jul-28	jan-29	dez-29	6 meses	11 meses	jul-31	36 meses

Terreno e Incorridos

TOTAL (R$ + Perm.):	12,63 MM	Incorrido Terreno: 0,00 MM	Área do Terreno (100%):	51.603 m²	Área Líquida do Terreno: 34.241 m²
Cash:	0,00 MM		Custo de terreno m²:	244,7	Custo de terreno m² Área Líquida: 368,8
Permuta Financeira:	12,63 MM (11,00%)		VaR 25 (R$ mil):	0	Fração Terreno/Terreno + Custo Obra (%VGV): 11,0% / 57,2%
Permuta Física:	0,00 MM (0,00%)		VaR 26 (R$ mil):	0	CA Máx/Proj. 1,0 / 0,4
Ato / %VGV:	0,00 MM / 0,0%		Incorrido de Construção:	0,00 MM	Incorridos de Incorporação: 0,00 MM

Vendas

Fases	Nº Pavimentos	Preço Raso Unit.	Qtde	Preço Unit.	Aval. CEF	Cond. Parcela	% Pró-soluto	% TCD
Raízes I e II F1	T+3	209.486	96	227.969	235.000	100,3%	85,3%	51,2%
Raízes I e II F2	T+3	193.614	164	216.538	220.000	98,0%	85,3%	71,1%
Raízes I e II F3	T+3	209.501	96	227.969	235.000	100,3%	85,3%	51,2%
Raízes I e II F4	T+3	193.729	164	216.538	220.000	98,0%	85,3%	71,1%

Unidades Totais:	520	Preço Médio:	220.758	Renda Média:	3.381	ITBI+Emol. Unit. Médio:	4.415
Unidades Tenda:	520	Avaliação Média:	225.538	Ato:	1.871 (0,55 Salários)	Custo do Ciclo Unit.:	13.755
VSO:	20 Unidades	VGV Total:	114.794.389	FGTS:	2.250 (0,67 Salários)	Preço Raso Médio:	199.514
RET Médio:	2,8%	VGV Tenda:	114.794.389	% em RET 1%:	41%	Adc. Tx. de Aceleração Médio:	800

Construção

Custo Total Unit.:	101.995	Eventuais:	2,00%	Área priv (m²):	34,90	Gape / Mês Unit.:	11,08

Resultado

LI (R$):	13.139.288	LI:	19,99%	Exposição de Caixa (R$):	8.949.351	Margem Bruta Econômica:	36,94%
TIR:	190,20%	LI Aprovação:	20,00%	Ger. Caixa 12 meses (R$):	0	Margem Bruta REF:	39,86%
Exposição de Caixa:	6,89%	Δ LI:	-0,01%	Ger. Caixa 24 meses (R$):	(679.347)	Margem Rasa Econômica:	29,67%
Payback Contingente (21 m):	15 m/ (-6 m)	LI Resiliência:	14,71%	Ger. Caixa Marginal (R$):	30.982.193	Margem Rasa REF:	33,47%
Payback Consolidado:	15 meses					Margem de Contribuição Econômica:	25,49%

DRE

R$ Mil - Valores Nominais - Compra	Raízes I e II		Primeira Fase		Demais Fases	
	Nominal	%	Nominal	%	Nominal	%
Receita	129.871	100,0%	63.220	100,0%	66.650	100,0%
PIS/COFINS	(1.982)	1,5%	(965)	1,5%	(1.017)	1,5%
Custo Total	(80.647)	63,1%	(39.477)	63,4%	(41.169)	62,7%
Custo Terreno	(13.571)	10,6%	(6.607)	10,6%	(6.965)	10,6%
Custo Relacionados a Terreno	(57)	0,0%	(28)	0,0%	(29)	0,0%
Custos de Incorporação	(1.905)	1,5%	(945)	1,5%	(960)	1,5%
Custo de Construção	(65.113)	50,9%	(31.898)	51,2%	(33.215)	50,6%
Lucro Bruto Econômico	47.242	36,9%	22.778	36,6%	24.464	37,3%
Custo para Rateio	-	0,0%	-	0,0%	-	0,0%
Lucro Bruto Contábil	47.242	36,9%	22.778	36,6%	24.464	37,3%
Despesas de Selling	(11.651)	9,1%	(5.671)	9,1%	(5.979)	9,1%
Contingência	(2.987)	2,3%	(1.454)	2,3%	(1.533)	2,3%
Margem de Contribuição	32.604	25,5%	15.652	25,1%	16.952	25,8%
IR e CSLL	(1.622)	1,2%	(790)	1,3%	(832)	1,3%
Margem Líquida	30.982	24,2%	14.863	23,9%	16.119	24,6%

R$ Mil - VPL - Compra	Raízes I e II		Primeira Fase		Demais Fases	
	VP	%	VP	%	VP	%
Receitas	65.715	100,0%	35.096	100,0%	30.619	100,0%
PIS/COFINS	(988)	1,5%	(528)	1,5%	(461)	1,5%
Custos e Despesas Totais	(51.587)	78,5%	(27.669)	78,8%	(23.919)	78,1%
Custo Terreno	(6.573)	10,0%	(3.511)	10,0%	(3.063)	10,0%
Custo Relacionados a Terreno	(42)	0,1%	(20)	0,1%	(22)	0,1%
Custos de Incorporação	(1.158)	1,8%	(631)	1,8%	(528)	1,7%
Custo de Construção	(35.419)	53,9%	(19.024)	54,2%	(16.395)	53,5%
Despesas de Selling	(6.741)	10,3%	(3.600)	10,3%	(3.141)	10,3%
Contingência	(846)	1,3%	(452)	1,3%	(394)	1,3%
IR e CSLL	(809)	1,2%	(432)	1,2%	(377)	1,2%
Lucro Imobiliário	13.139	20,0%	6.899	19,7%	6.240	20,4%

Pareceres

Análise da Mancha e Implantação

Prospecção

Operações

Inteligência de Mercado

Financeiro

Pareceres anexos

➢ ÁREA DE IMPLANTAÇÃO E DIRETRIZES URBANÍSTICAS:

- Por meio de Consulta com a SMUR, foi relatado que até a profundidade de 60 m, a partir do alinhamento predial, o lote é atingido pelo Eixo de Centralidade (ECEN). A partir desta profundidade, podem ser adotados tanto os parâmetros previstos para a Zona Residencial 1 (ZR1), zona a qual se insere o lote, quanto para Zona Residencial 2 (ZR2), conforme o §3º do Art. 14 da LC 25/2020, que permite o espelhamento do zoneamento.
- Como a ZR2 possui frente apenas em uma das testadas do lote, o espelhamento de seus parâmetros só é permitido em relação a esse trecho específico da Avenida Independência. Dessa forma, para que ambos os condomínios adotem os parâmetros da ZR2, é necessário que ambos tenham testada voltada para esse trecho da via , conforme orientado no Plantão do DU. No entanto, foi validado que os acessos aos condomínios podem ocorrer por qualquer uma das testadas.

➢ ÁREA DE IMPLANTAÇÃO E DIRETRIZES URBANÍSTICAS:

- Para tanto, foram adotados os parâmetros da zona mais restritiva:
  - **Coeficiente de aproveitamento:** Básico igual a 1,5;
  - **Taxa de Ocupação:** 50%;
  - **Área mínima permeável:** 20%;
  - **Recuo Frontal:** 5 m;
  - **Afastamento de divisas:** 2 m;
  - **Afastamento entre torres:** (h/6)x2 (mín. 5 m);
  - **Altura Máxima:** 12 pavimentos;
  - **Densidade:** Máximo de 260 UH por condomínio;
  - **Tipologia:** T+3; 16 PP e 18 PP;
  - **Vagas de estacionamento:** 105% (100% comum + 5% de visitantes, conforme Lei nº 26/2020). No projeto foi acrescentado vaga de Carga e Descarga.

Legalização/Implantação

➢ FAIXA DE DOMÍNIO DA FERROVIA:

- Conforme observado no Levantamento Planialtimétrico, o lote é atingido pela faixa de domínio da Rede Ferroviária, com 15 m a partir do eixo do canteiro central, em uma área de 541,83 m². No entanto, trata-se de um equívoco, uma vez que essa faixa é de propriedade da União e, portanto, não deve pertencer ao lote;
- Foi orientado pelo DNIT que o método mais ágil é a realização da retificação administrativa da matrícula do imóvel, o qual pode ser aberto requerimento endereçado ao Superintendente do DNIT/PR ;
- Além disso, conforme exigência municipal, devem ser reservados 15 m de Faixa Não Edificável a partir da faixa de domínio da ferrovia. A área consiste em 3.071,04 m².

➢ ATINGIMENTO VIÁRIO:

- Conforme observado no Levantamento Planialtimétrico, o lote possui um atingimento viário, referente ao alargamento da Av. Independência, com cerca de 680,61 m², o qual será destacado e doado ao Poder Público durante o processo de subdivisão.

➢ REGULARIZAÇÃO DA ÁREA:

RETIFICAÇÃO

- Será necessária a retificação da área, de forma a destacar a faixa de domínio da ferrovia, além de regularizar a metragem total do lote. Ressalta-se que as medidas perimetrais e os ângulos estão compatíveis com os dados constantes na Matrícula nº 25.361, sendo as divergências relacionadas à área computada e aos atingimentos.
    - Área matrícula: 53.438,00 m²
    - Área medida (reconst. Mat.): 52.144,96 m²
    - Área retificada (descontado a faixa de domínio): 51.603,12 m²

AVU

- Deverá ser realizada a averbação de Área Verde Urbana relativa a 20% da área da matrícula retificada (pelo menos 10.184,50 m² - previsto 10.332,97m²).
    - A AVU de 20% foi definida em atendimento à exigência do IAT, órgão licenciador estadual, tendo em vista a inexistência de previsão legal municipal específica sobre o percentual a ser doado. Ressalta-se que, conforme parecer jurídico recente emitido pelo próprio IAT, as áreas de atingimento viário não devem ser computadas para fins de atendimento a essa exigência.

➢ REGULARIZAÇÃO DA ÁREA:

SUBDIVISÃO E DOAÇÃO

- Deverá ser realizada a doação de área institucional de no mín. 10% da área líquida da matrícula retificada, sendo que 10% deverá ser útil (mínimo de 5.092,25 m² - sendo prevista com 6.348,16m² total e 5.261,24m² útil) ;
    - Conforme o Processo 72578/2025, foi verificada a possibilidade de receber a área institucional na porção indicada, desde que sejam atendidas as exigências da LC nº 26/2020, principalmente com relação ao fator de declividade máxima de 15%, exigindo movimentação do solo, supressão de vegetação, drenagem e doação do atingimento viário.

- A subdivisão ocorrerá em um único ato, no qual serão formalmente definidas as áreas correspondentes aos dois condomínios, a área de doação institucional e a área de atingimento viário.
- Área do terreno descontado o atingimento viário: 50.922,52 m²
- Área após subdivisão (descontado o atingimento viário e doação): 44.574,36 m²
- Área líquida (descontado a AVU): 34.241,35 m²
- Foram adotados os parâmetros de parcelamento do solo mais restritivos, correspondentes à ZR1.

➢ AVALIAÇÕES AMBIENTAIS:

CND AMBIENTAL

- Declaração de Débitos Financeiros Ambientais indicou a inexistência de débitos vinculados ao terreno.

VEGETAÇÃO

- 24,07% de gramíneas, herbáceas e árvores Isoladas = 12.553,36 m²
- As árvores isoladas = 1,0052 m³ (3 indivíduos, sendo 1 árvore nativa e 2 árvores exóticas)
- 18,50% de Vegetação Secundária em Estágio Inicial de Regeneração = 9.645,55 m², 202 árvores (1 morta).
- 57,43% de Vegetação Secundária em Estágio Médio de Regeneração = 29.946,05 m², 231 árvores (1 morta e 1 cipó)
- Espécies ameaçadas:1 indivíduo de xaxim-bugio (em perigo), 1 indivíduo de cedro-rosa (vulnerável) e 7 indivíduos de araucária (em perigo, sendo 6 localizados na linha da divisa oeste do imóvel), na área de Vegetação Secundária em Estágio Médio de Regeneração.
- Supressão: pode ser cortado/suprimido 100% da área com vegetação secundária em estágio inicial (9.645,55 m²); 70 % da área com vegetação secundária em estágio médio (20.962,24 m²) e 100% da área ocupada com gramíneas, herbáceas e árvores isoladas (12.553,37 m²).
- Xaxim-bugio realocado para a Área Verde Urbana, araucárias mantidas.
- Os cedros a serem suprimidos serão compensados por meio do enriquecimento na Área Verde Urbana com o plantio de 10 mudas.
- Plantio de 1 árvore a cada 4 vagas (LC nº 26/2020): contabilizadas 175 árvores (82 no Raízes I e 93 no Raízes II) em AP.

➢ AVALIAÇÕES AMBIENTAIS:

TOPOGRAFIA

- O relevo da área é predominantemente suave ondulado com porções de caráter suave ondulado na porção central, chegando a plano em direção a nordeste na parte mais baixa do terreno.
- A variação de altitude dentro dos limites do terreno é de 877 a 892 metros (15 metros).
- O terreno possui variações de declividades, com regiões com baixas declividades (5 a 10%) e áreas mais acentuadas (15 a 20%).
- Há dois taludes provenientes de ações antrópicas onde são superados os valores de 45%, um junto à avenida da Independência e outro juntamente ao aterro de detritos da porção sul do imóvel.

CORPOS HÍDRICOS

- No terreno não foram detectados corpos hídricos ou APP em seu interior.

COTA DE INUNDAÇÃO

- Conforme o Estudo Hidrológico, as modelagens realizadas para as vazões de pico da para os tempos de retorno de 10, 20, 100 e 200 anos indicam que a mancha de inundação do rio Passaúna e de seu afluente, permanece restrito a planície de inundação do rio Passaúna, não atingindo o terreno.

LAUDO ACÚSTICO

- O laudo foi elaborado pela proximidade com a Rede Ferroviária F. Nova, sendo verificado nível de ruído Classe I em todas as fachadas.

➢ AVALIAÇÕES AMBIENTAIS:

SOLO

- Foram executados 06 furos de sondagem a percussão - SPT, num total de 62,70 metros de perfuração.
- O solo é caracterizado por uma camada vegetal com profundidade entre 0,36 e 0,56 m, que representa material orgânico superficial.
- A seguir, nos trechos próximos a ferrovia há uma camada de argila silto-arenosa de cor marrom média, com profundidade de até 2,55 m.
- A sondagem continua com uma camada de argila silto-arenosa, cor vermelha, rija, que se estende até cerca de 4,90 m.
- Em seguida, até a profundidade máxima registrada, o solo é composto por argila arenosa, cor vermelha, dura.
- A profundidade máxima onde o solo se mostrou impenetrável ao amostrador é de 10,45 m.
- O nível freático não foi interceptado nas sondagens realizadas na área.

CONTAMINAÇÃO

- Não há indícios prévios, por isso não foi solicitado o Laudo de Contaminação.

➢ DRENAGEM:

- O imóvel não apresenta Faixa Não Edificável de Drenagem (FNED).
- No levantamento percebeu-se que a drenagem ocorre principalmente em superfície, na direção às porções mais baixas do terreno.
- Inexistência de talvegues de drenagem superficial na propriedade.
- Pela declividade do terreno o normal nos períodos de precipitação mais intensa a água que não infiltra, escorre para oeste-noroeste.

➢ ABASTECIMENTO DE ÁGUA E ESGOTAMENTO SANITÁRIO:

- Carta de viabilidade emitida pela Sanepar em abril de 2025.
- Há possibilidade de atendimento com necessidade de ampliação de rede de distribuição de água, em DN 75, com interligação em rede existente DN250, extensão aproximada de 80 metros (Ponto de interligação: Av. Independência).
- Há possibilidade de atendimento com necessidade de ampliação e reforço de rede coletora de esgoto, em DN 200, com extensão aproximada de 600 metros (Ponto de interligação: Av. Independência).
- Custos de extensão de rede são suportados pela Sanepar.

➢ VIABILIDADE DE ELÉTRICA:

- Carta de viabilidade da Copel recebida em março de 2025, atestou a viabilidade técnica.

➢ OUTRAS INFRAS CONSIDERADAS EM AP:

- Foi considerada em AP a adequação da calçada existente na testada do empreendimento voltado a Avenida Independência, além da execução e continuidade no trecho restante até o limite da testada do imóvel.

➢ COMAER:

- Aguardando certidão de inexigibilidade de anuência da COMAER;

➢ ÓRGÃOS DE PATRIMÔNIO HISTÓRICO:

- Não há registros de bens tombados segundo o IPHAN e o Patrimônio Cultural do Paraná, sendo o bem mais próximo localizado a 2,69 km do empreendimento.

Legalização/DPP

➢ CUSTOS

Descrição do item	Status	Preço
Levantamento Planialtimétrico	Ok	R$ 12.116,36
Laudo florístico	Ok	R$ 3.180,00
Laudo hidrogeológico	Ok	R$ 9.180,00
Sondagem SPT	Ok	R$ 5.000,00
Cota inundação	Ok	R$ 15.320,00
Laudo acústico	A pagar	R$ 5.950,00
RGRCC (Elaboração final + 11 meses de acompanhamento)	A pagar	R$ 72.000,00
IPHAN	A pagar	R$ 12.000,00
PGRCC	A pagar	R$ 6.000,00
Taxas municipais	Ok	R$ 59,81
Taxas municipais	A pagar	R$ 61.684,97
Contrapartidas EIV	A pagar	R$ 526.322,55
Quadro NBR	A pagar	R$ 10.000,00
TOTAL		**R$ 738.813,69**

Obrigado