Tenda

sua próxima conquista

Comitê Essencial

Regional: SP – Zona ZS1 – CLUSTER 5

Projeto: Americanópolis

Data Comitê: 17.06.2025

One Page – Americanópolis

Cidade	São Paulo	**Mancha de demanda**	SP - SZS1 - São Paulo Sul 1
Regional	SP	**Cluster MPR**	5 - Roxo
Cenário de Aprovação	Aprovação	**Tipo de Aprovação**	Consolidado
Fase Anterior	NA		
Tipo de Comitê	Essencial	**Versão da VF**	Versão 1.0: Jun

Unidades (% Vagas)	707 (0%)	**CA Máx | Proj**	10,2 | 4,3
Tipologia	F2E - Concreto	**Escritura**	jun-27
Fases	1 fases	**Lçto | Duração (m)**	ago/27 | 28

Valor Líquido do Terreno (% VGV)	23.000 (12,7%)	**Un. Perm. Fís (% Ter)**	0 (0,0%)
Cash (Correção)	23.000 (IPCA)	**%VGV Perm Fin Líquida (% Ter)**	0,0% (0,0%)
Valor R$/m²	5.273	**VAR (%VGV)**	000 (0,0%)

Custo Construção (%VGV)	70.183 (38,8%)	**Indireto Unit.**	17.303
Prazo da Obra (meses)	22	**Torre Unit.**	56.662
Custo Total Unit. | Corrigido (LPU):	99.269 | 99.781 (89)	**Infra Unit.**	15.301
Início de Obra	fev-28	**Fundação Unit.**	8.424

Preço Nominal Unit.	255.663	**VSO**	38
Preço Raso Unit.	247.267	**Referência**	Vision
Avaliação Unit.	277.595	**Renda (% em RET 1%)**	4.495 (13,0%)

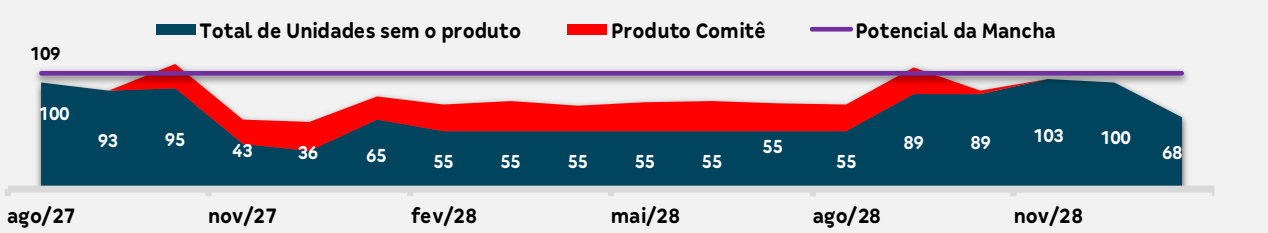

LI (Régua):	**20,0% (20,0%)**	**Margem Bruta Econômica:**	37,7%
LI Resiliência:	11,7% (N/A)	**Margem Rasa Econômica:**	35,3%
Margem Bruta REF:	41,8%	**Margem Contribuição Econômica:**	25,9%
Margem Rasa REF:	**39,9%**	**Exposição (% VGV):**	22.565 (11,4%)
TIR:	104,0%	**VGV Total:**	180.754
Payback Contingente (21 m) :	**19 m/ (-2 m)**	**Ger. Caixa 12 meses (R$):**	(785)
Payback Consolidado:	19	**Ger. Caixa 24 meses (R$):**	(1.137)

Destaques

[1] O Terreno está localizado na Av. Yervant Kissajkian, Interlagos, mancha ZS1 – Zona Sul de São Paulo. Localização na melhor mancha da ZS, com frente para avenida, com grande número de comércios e serviços e a 5,4km da estação Socorro linha esmeralda; entorno com empreendimentos de padrão superior – vide slide 7.

[2] O projeto é composto por 1 condomínio com 707 unidades, zero vagas, fase única; Considerado 48% de unidades com varanda e piscina como principais atributos; Terreno com zoneamento ZEIS3, sem limite de gabarito, porém terrenos estreitos como esse impactam nos afastamentos exigidos, por isso não foi possível utilizar o T+25; O gabarito que normalmente atende esses afastamentos é o T+17; O CA atingido de 4,3x já considera a não ocupação na FNA aos fundos do terreno – sem a FNA o CA poderia atingir por simulação 5,16x; Temos ainda a possibilidade de implantação de prumada de 1 dorm junto ao core, trazendo um CA adicional de aproximadamente 0,2X.

[3] Condição Comercial: 100% Dinheiro
Valor total: R$ 23MM -> Representa R$ 4.390,00/m2 e aproximadamente R$ 1.002/CA atingido.

- Sinal: R$ 700 mil pagos na superação da resolutiva tranche I; o valor do sinal de R$700 mil será garantido por Alienação Fiduciária em que a Vendedora devolverá R$150.000,00 em caso de rescisão motivada pela Tenda, e 100% em caso de rescisão motivada e/ou culpa da Vendedora.
- Saldo em 36 parcelas com início mediante aprovação do projeto e lavratura da escritura.

a) Intermediação: R$ 912 mil que representa 4% do valor do negócio.
b) Garantia Fidejussória da Tenda.

[4] Comitê no formato Essencial com consideração de 70% do total de unidades para a meta; temos expectativa de voltarmos para comitê ampliado no 2S25.

Pareceres

Análise da Mancha e Implantação

Prospecção

Operações

Incorporação

Inteligência de Mercado

Financeiro

Anexos

Pareceres Americanópolis

Área	Riscos Associados	Parecer	Flag
Jurídico Aquisição	De acordo com a DD prévia entendemos ser viável darmos andamento aos próximos atos a serem praticados para a efetiva aquisição do terreno e que na DD detalhada em conjunto com estudo jurídico e técnico teremos maiores informações sobre o imóvel e proprietários	Ok com ressalvas	
Legalização	Sem riscos associados.	Ok	
DPP	Sem riscos associados.	Ok	
Inteligência de Mercado	IM avalia o Preço Vision como factível	Ok	
Estudos Econômicos	Ok,para o comitê essencial	Ok	
Ciclo Financeiro	O Ciclo avaliou Preço e VSO como factíveis	Ok	

Pareceres

Análise da Mancha e Implantação

Prospecção

Operações

Incorporação

Inteligência de Mercado

Financeiro

Anexos

Localização – Av. Yervant Kissajkian, 416 A – Interlagos – São Paulo - SP

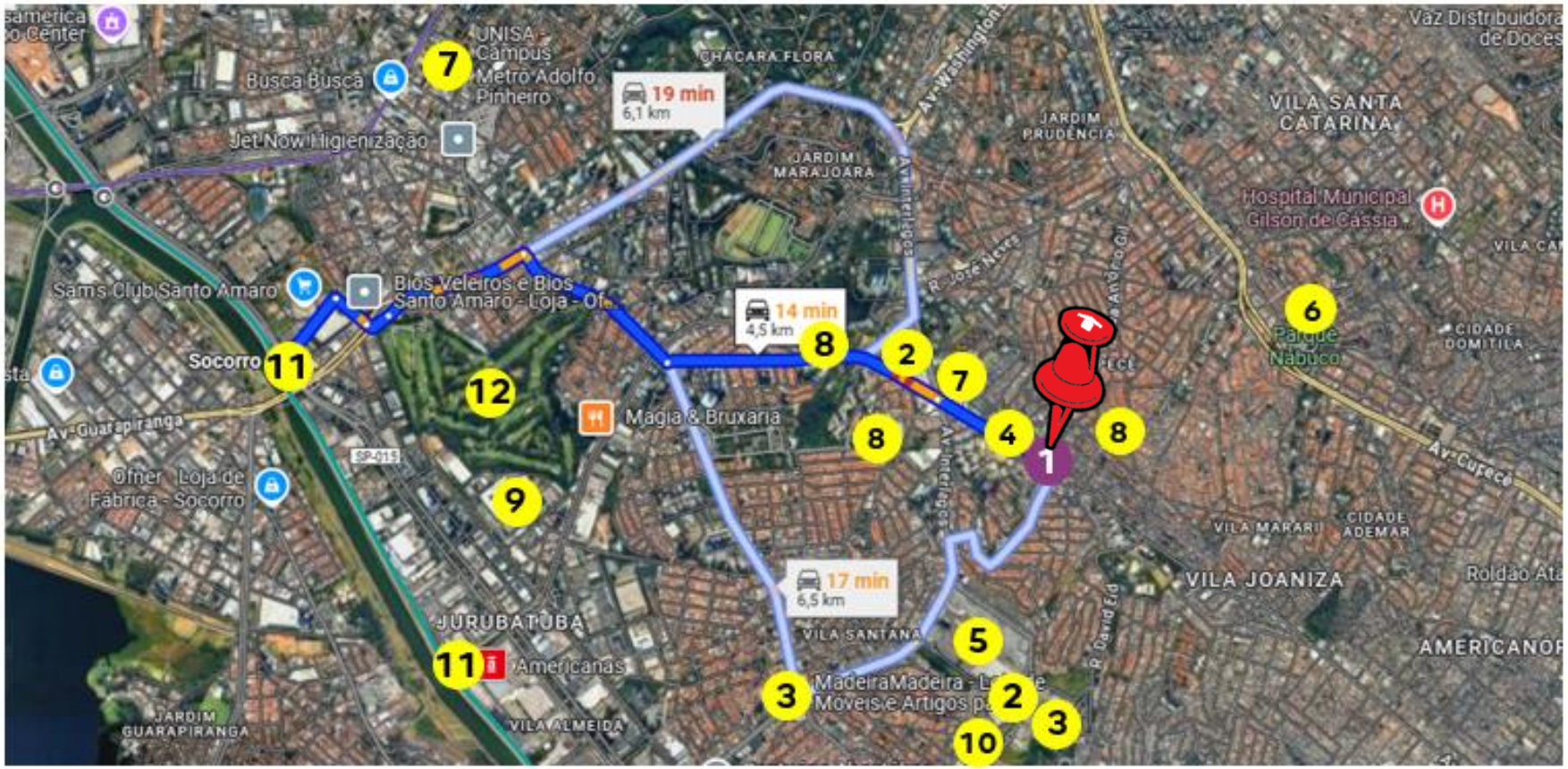

2 Hipermercado Carrefour e Max Atacadista

3 Home center Leroy e Madeira Madeira

4 Subprefeitura Cidade Ademar

5 Shopping Interlagos

6 Parque Municipal Nabuco

7 Universidade Ibirapuera e Unisa Adolfo Pinheiro

8 Escola Estadual Prof. Zenaide Lopes, Ibrahim Nobre e Colégio Santa Maria

9 Senac Santo Amaro

10 Hospital Geral da Pedreira e Hospital

11 Estação de Trem (LINHA 9 ESMERALDA) – Socorro (30 Min de ônibus) e Jurubatuba (22 min de ônibus)

12 Golf Club - SP

1 Yervant 416

Localização – Av. Yervant Kissajkian, 416 A – Interlagos – São Paulo - SP

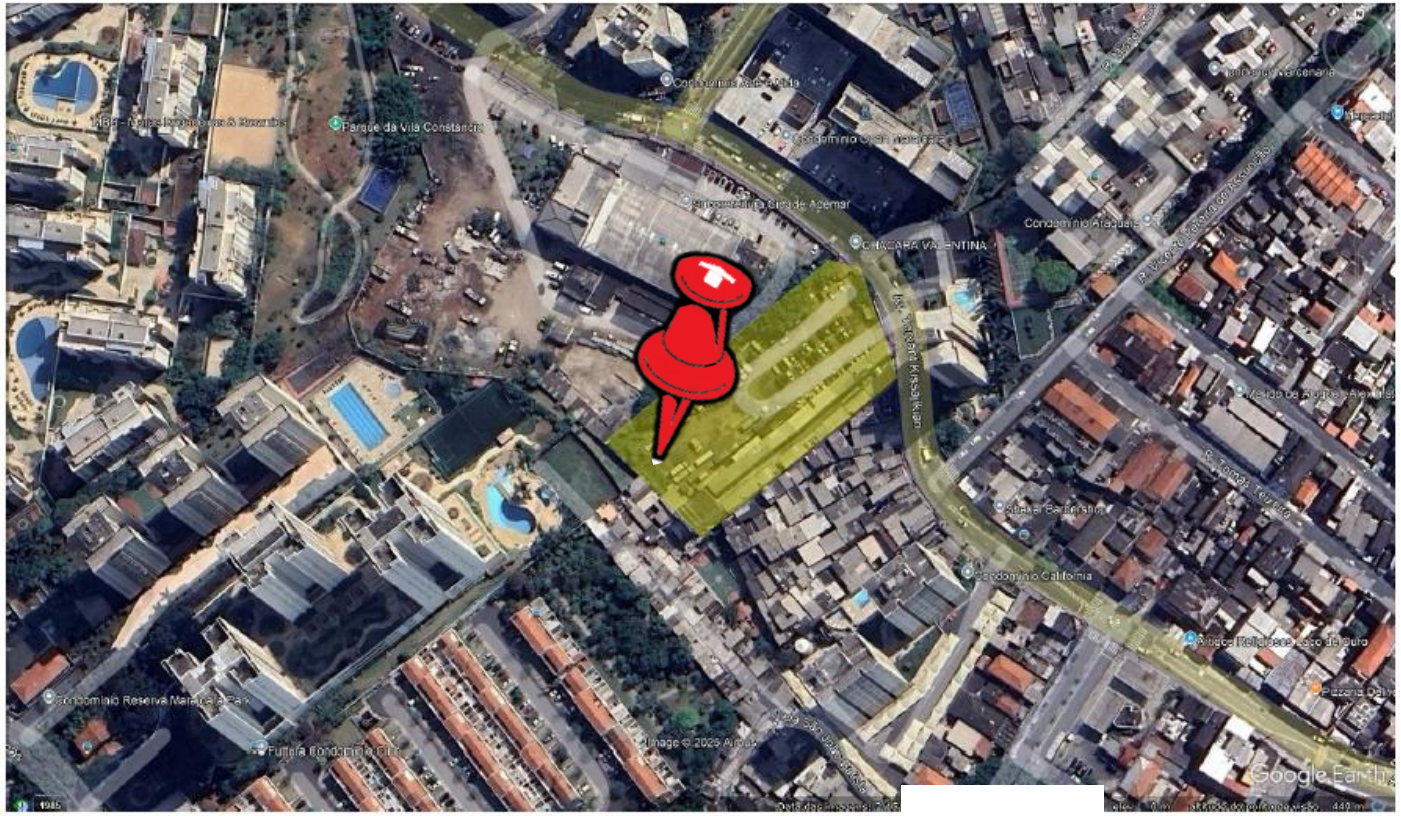

Mancha de Demanda

MANCHAS DE DEMANDA
- SZS – São Paulo Sul

Lançamento
1. Vista Granja Julieta
2. V. Vila das Belezas

LandBank
3. Essência do Campo
4. Dália
5. Moove Santo Amaro
6. Americanópolis

Cluster MPR – (Comitê)

Cluster 5 - Roxo

Região

Capital

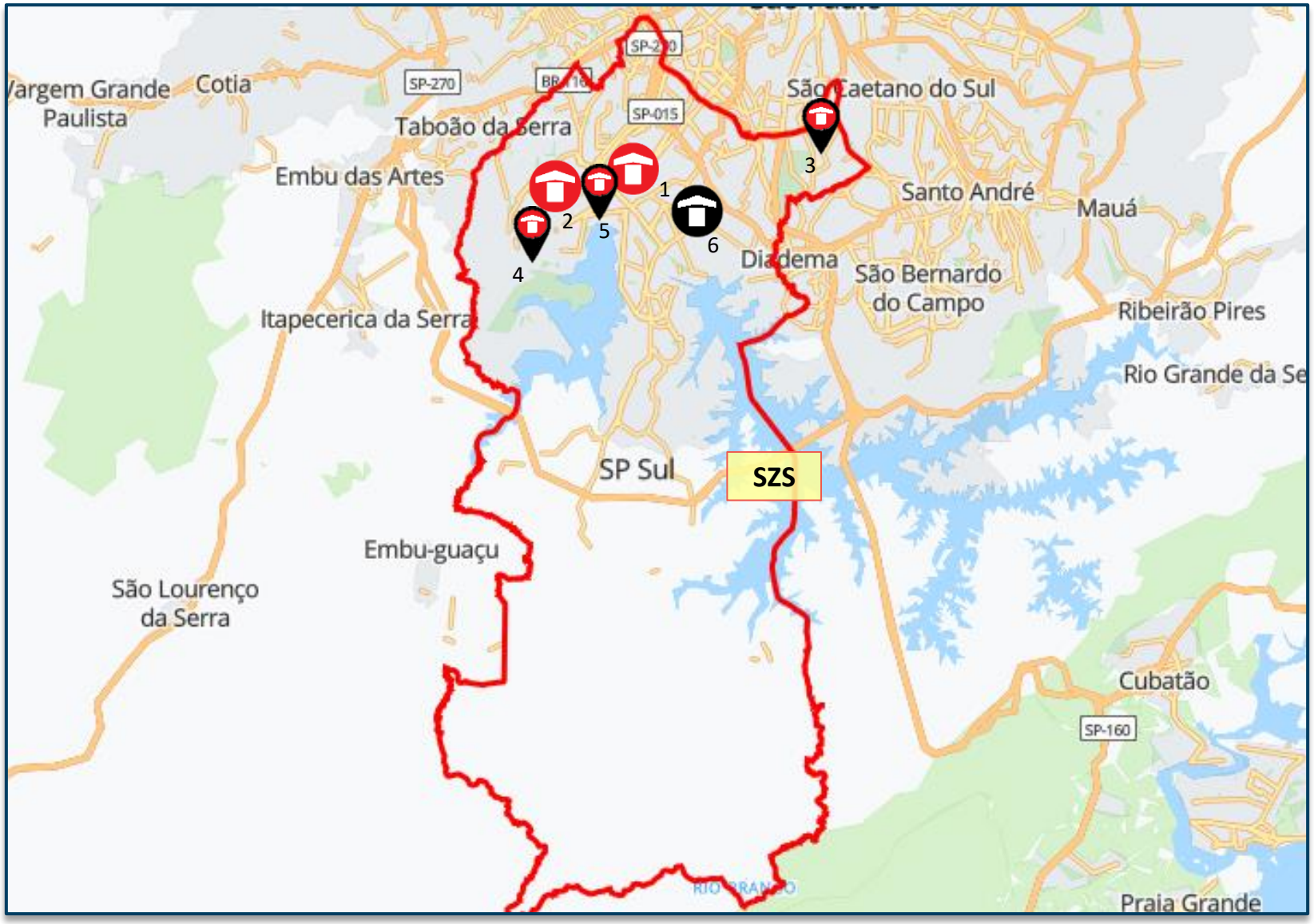

Lançados *LandBank* *Comitê*

PRODUTO

Yervant II
Investimento

Informações Gerais – Condomínio Único			
Terreno	Área terreno	5.241,44m²	
	Menor poligonal	5.241,44m²	
	FNA	Sim - 739,15m²	
	Área liquida	4.362,05m²	
	Zoneamento	ZEIS-3	
	CA máximo	10,20	ZONA: 4,0
			INCENTIVO HIS1: 2,0
			INCENTIVO HIS1 E 2: 2,0
			INCENTIVO HMP: 1,0
			COTA: 1,20
	CA projetado	4,30	
	Gabarito máximo	N/A	
Geral	Total UH	707	
	Total de vagas	0	
Tipologia	Tipologia	V0200 20PP-LF-C	
	Gabarito	T+17	
	Lâmina	02 X 20PP-LF-C	
	Área privativa	31,86m²	
Condomínio	Unidade PCD	10	
	Unidade lazer | técnica	11 | 02	
	Torre	02	
	Fase	Única	
Lazer	Lazer coberto	1x Churrasqueira	
	Lazer descoberto projetado	1.446,74 m²	

LEGENDA:

01 FNA Drenagem
02 Reserva de calçada
03 Face com Varanda
04 Lazer

ESTUDO DE MASSAS

PRODUTO

Yervant II
Investimento

	Descrição	Criticidade	Parecer
Usabilidade	**Acesso Empreendimento**	🟢	
	Percurso do pedestre até torre	🟢	
Diferencial produto	**Prime**	Não	
	Supercondomínio	Não	
	Atributos Infra	Sim	Piscina
	Atributos Torre	Sim	Varanda (340UH com varanda, representa 48% do tota)
	Edifício Garagem	Não	

	Considerações	Criticidade	Descrição
Material analisado	KMZ	🟢	
	Mapa Digital da Cidade 2004	🟢	
	Matrícula	🟡	Descrição da matrícula e FNA não são precisas, apresentam divergência quando comparadas ao MDC
Projeto	Área líquida	🟡	Identificado melhoramento viário, referente a PRM LEI 243/1969, que tem possibilidade de ser descaracterizado.
		🟡	Identificado uma FNA incidindo em todo o terreno, porém a averbação na matricula georeferencia apenas no fundo do terreno.
	Topografia	🟢	Baseado nas curvas de nível indicadas no MDC, a implantação proposta pode gerar aterros de aprox. 4m
	Drenagem	🟢	A FNA existente corresponde a um córrego canalizado, se não for possível ligar a drenagem nesse ponto, precisaremos prever recalque.

Pareceres

Análise da Mancha e Implantação

Prospecção

Operações

Incorporação

Inteligência de Mercado

Financeiro

Anexos

Condições do Negócio

- **VALOR DO NEGÓCIO:**

- R$ 23.000.000,00 –> R$ 4.390,00/m2 e aproximadamente R$ 1.002/CA atingido.

- **FORMA DE PAGAMENTO:**
  - Sinal: R$ 700 mil – previsão de pagto em ago/2025 após conclusão da tranche I de resolutivas – podendo ser prorrogado a depender da efetivação da resolutiva;
    - O valor do sinal de R$700.000,00 será garantido por Alienação Fiduciária, em que a Vendedora devolverá R$150.000,00 em caso de rescisão motivada pela Tenda, e 100% em caso de rescisão ou culpa motivada pela Vendedora.
  - Saldo: Em 36 parcelas mensais consecutivas, com início após a aprovação do projeto e mediante escritura.
- **CORREÇÃO:**

Não aplicável sobre a parcela de sinal. Aplicável sobre o saldo e com data base após a conclusão da tranche II de resolutivas – prevista para fev/2026.

- **GARANTIAS**: Fidejussória da Tenda.

- **ESCRITURA E POSSE:** Concomitante à superação integral das resolutivas do contrato.

- **CORRETAGEM:** R$ 912mil, que representa aproximadamente 4%

- **PRAZOS:**

Último aditamento contratual assinado em 19/05/2025;
Tranches de Resolutivas:
a) I: Terreno livre de coisas e pessoas até 12 meses – Previsão de superação: Agosto/2025 **
b) II: Prazo 120 dias para resolutivas técnicas após a superação Etapa I, resolutivas jurídicas e financeira – Previsão fev/2026
c) III: Em até 12 meses após a superação da Etapa II (passível de postergação) para aprovação de projeto, contratação CEF, análise técnica, financeira e comercial para o lançamento do empreendimento – Projeção para ago/2027

** Status atual: parte do terreno tem uma ação de despejo transitada em julgada e mandato de despejo expedito | Fase final de reuniões (CET, Policia Militar, Bombeiros, Defesa Civil, Defensoria Pública, Detran e a Oficial de Justiça) para agendamento do dia do despejo – previsão de execução em 2 meses

Pareceres

Análise da Mancha e Implantação

Prospecção

Operações

Incorporação

Inteligência de Mercado

Financeiro

Anexos

Custo de Construção – SIMULADOR

PARÂMETROS

Empreendimento:	Av. Yervant, 416A - Americanópolis			INCC base:	1.178,39
Produto / Selo:	F2E Modular	Contenção:	Nível 2	Prazo pré forma:	5,4
Pavimentos Médio:	18	Terraplenagem:	Nível 2	Prazo forma:	7,3
Torres:	2	Varanda %:	48%	Prazo pós Forma:	9,0
PPs médio:	20,0	Piscina:	Sim	Prazo total:	22,0
Unidades Construídas:	707	ETE:	Não	EEE:	Não

Infra Externa

Viário (m):	0	Extensão Esgoto (m):	36
Drenagem (m):	0	Extensão Água (m):	0

Obras ref. contenção

Portal Do Parque
Viva City Jaraguá F1
Life Jaguare
Palermo

Obras ref. Terraplenagem

Vista Granja Julieta
Portal Do Parque
Viva São Miguel

Custo de Construção - SIMULADOR

	CUSTO	R$ / UND
CUSTO TOTAL I	**R$ 69.274.364**	**R$ 98.963**
INDIRETO	R$ 12.112.177	R$ 17.303
TORRE	R$ 39.918.278	R$ 57.026
INFRA	R$ 10.647.423	R$ 15.211
FUNDAÇÃO	R$ 5.896.978	R$ 8.424
ETE	R$ 0	R$ 0
EEE	R$ 0	R$ 0
CONTENÇÃO	R$ 106.073	R$ 152
TERRAPLENAGEM	R$ 593.435	R$ 848
CUSTO TOTAL II	**R$ 214.102**	**R$ 306**
VIÁRIO	R$ 0	R$ 0
DRENAGEM	R$ 0	R$ 0
EXTENSÃO ELÉTRICA	R$ 100.000	R$ 143
EXTENSÃO HIDRÁULICA	R$ 114.102	R$ 163
CUSTO TOTAL I + II	**R$ 69.488.466**	**R$ 99.269**
CUSTO TOTAL III	**R$ 0**	**R$ 0**
INCORRIDOS NÃO APROVEITADOS	R$ 0	R$ 0
CUSTO TOTAL I A III	**R$ 69.488.466**	**R$ 99.269**
CUSTO TOTAL I A IV	**R$ 69.488.466**	**R$ 99.269**

DADOS DA OBRA

Regional:	SP
Endereço:	
Total de UH:	**707**
Total Torres:	2
Produtos:	F2E Modular
Tipologia:	MODULAR 10PP/16PP T+15

BASES

Data:	junho-25
Revisão:	R00
LPU:	LPU 89
LVS:	março-25
INCC:	1.178,386

PRAZOS DE OBRA

Pré Forma:	5,4 meses
Estrutura:	7,3 meses
Pós Forma:	9,0 meses
TOTAL:	**22,0 meses**
Jogos de Formas:	2
Takt:	2+2

Pareceres

Análise da Mancha e Implantação

Prospecção

Operações

Incorporação

Inteligência de Mercado

Financeiro

Anexos

Demanda e Distribuição da Mancha

Potencial de Demanda			Lançados		Lançados + Landbank	
Mancha	CÓD.	Shr.	ANO	MÊS	ANO	MÊS
São Paulo Sul	SZS	21%	1.459	122	1.750	146

Empreendimento	Renda	Lançamento	abr/27	mai/27	jun/27	jul/27	ago/27	set/27	out/27	nov/27	dez/27	jan/28	fev/28	mar/28	abr/28	mai/28	jun/28	jul/28	ago/28	set/28	out/28	nov/28	dez/28	jan/29
Dália	2.992	out-25	28																					
Essência Do Campo Fase 1	3.584	fev-26	31	31	31	31	23																	
Americanópolis	**4.495**	**abr-27**		**38**	**38**	**38**	**38**	**38**	**38**	**38**	**38**	**38**	**38**	**38**	**38**	**38**	**38**	**38**	**38**	**38**	**38**	**23**		
Essência Do Campo Fase 2	3.584	jul-27					20	20	20	20	20	20	20	20	20	20	20	20	20	20	20	20	20	14
Moove Santo Amaro	3.266	nov-27									55	55	55	55	55	55	55	55	55	55	55	55	55	55
Total de Vendas Lançados			**0**	**0**	**0**	**0**	**0**	**0**	**0**	**0**	**0**	**0**	**0**	**0**	**0**	**0**	**0**	**0**	**0**	**0**	**0**	**0**	**0**	**0**
Total de Vendas Lançados + Landbank			**59**	**69**	**69**	**69**	**81**	**58**	**58**	**58**	**113**	**113**	**113**	**113**	**113**	**113**	**113**	**113**	**113**	**113**	**113**	**98**	**75**	**69**

Parecer de I.M sobre a mancha:

O projeto analisado em comitê está em linha com o potencial teórico de demanda calculado para a mancha. (Total Lanç + Landbank)

Canibalização:

Sem Risco de Canibalização

Americanópolis | Mapa Concorrência

		Americanópolis	Meu Plano&Interlagos	Mundo Park
		TENDA	Plano & Plano	Plano & Plano
	Distância Tenda (km)		2,09Km	2,84Km
Região 1 Km	População	45.086	55.585	21.885
	Dens. Demográfica	14.444	17.808	7.011
	Renda (R$)	9.030	5.824	8.399
	Classe Social	B1 (8.1k a 16k)	C1 (2.7k a 4.6k)	B1 (8.1k a 16k)
	PEA Dia	31.915	28.499	14.802
Quantitativo	Lançamento	abr/27	jul/24	04/2025
	Unidades	707	1.882	642
	Estoque	707	135	354
	VSO	38	159	144
	Stockout	19	1	2
Qualitativo	Condomínios	1	1	1
	Torres	2	4	5
	Gabarito	T+17	T+23	T+15
	Plantas (m²)	32,03m² e 33,78m²	32m² e 32,31m² e 34,31m² e 39,62m² e 46,53m²	25m² e 31m² e 34m²
	Tipologia	2 Dorms	2 Dorms	1 e 2 Dorms
	Opções	Não	Garden	Não
	Varanda	Sim	Não	Não
	Suite	Não	Não	Não
	Dif. Entrega	Não	Piso nos dormitórios, lavanderia e banheiro.	Não
	Vagas	Não	Não	Não
	Lazer	Piscina pequena, Salão de Festas, Churrasqueira + demais itens padrão	Churrasqueira, Playground, Piscina Adulto e Infantil, Pet Care, Mini Mercado, Sala Funcional, Salão de Festas e Brinquedoteca.	Bosque, Campo de Futebol, Cinema, Decorado, Lago, Pet Place, Piscina, Piscina Aquecida, Piso Elevado, Praça, Quiosque,

Tipologias	Empreendimento	Americanópolis				Meu Plano&Interlagos			Mundo Park			
	Tipologia	HIS - Sem varanda	HIS - Com varanda	HMP - Com Varanda	R2V - Com varanda	HIS - Sem Varanda	HIS2 - Com Varanda	R2V Com Varanda	HIS2 Sem Varanda	HIS2 Com Varanda	R2V - Varanda	R2V - Varanda e Vaga
	Preço Nominal	234.999	254.119	278.000	288.254	229.085	243.055	258.492	261.354	279.589	291.745	344.423
	CEF	196.158	200.360	224.392	231.378	183.268	194.444	206.794	209.083	223.671	233.396	275.538
	Renda	3.693	4.199	5.519	5.689	3.350	3.750	4.450	4.550	5.500	5.700	-
	% Unidades	19%	21%	52%	8%	22%	7%	71%	-	-	-	-
	Dif Renda					-343	-1.769	-1.239	857	-19	11	-
	Farol de Factibilidade					●	●	●	●	●	●	-

Farol Renda

- ● Acima de 300
- ● Entre 0 e 300
- ● Abaixo de 0

Diagnóstico Concorrência

- Os produtos da Plano & Plano estão apresentando um bom volume de vendas na região. No entanto, o empreendimento Plano&Interlagos está performando com um target de preço e renda abaixo do previsto no parecer. É importante ressaltar que, no seu lançamento, 61% das unidades foram destinadas para o HIS, e parte dessas unidades foram comercializadas no Ret1 por 199 mil.
- O Mundo Park é um lançamento recente e ainda não possui todas as informações disponíveis. No entanto, está performando uma renda similar nas unidades com varandas.
- Apesar dos empreendimentos da Plano & Plano terem praticado preços e rendas abaixo do previsto no parecer, eles registraram um alto volume de vendas.

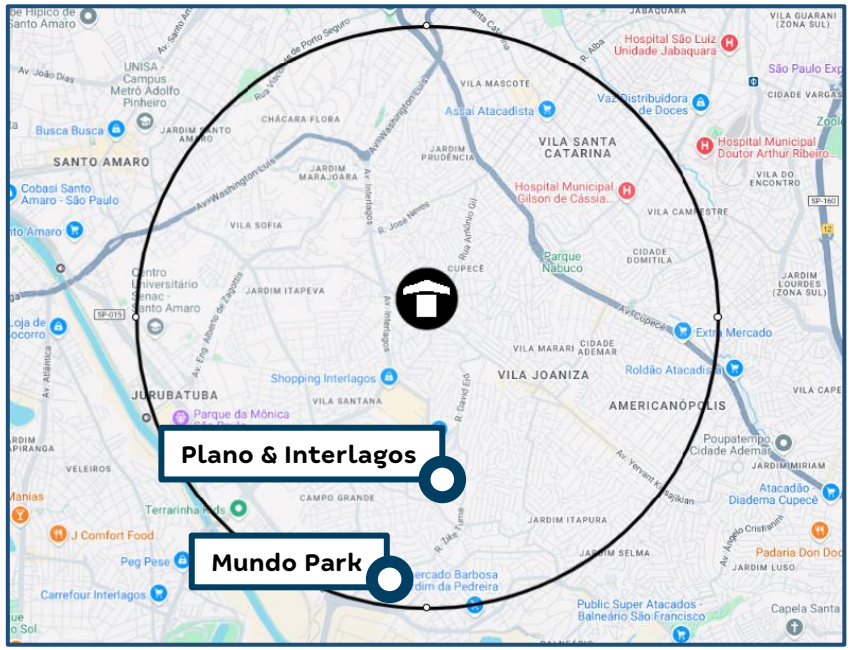

Simulação de Preço

Informações Viabilidade

Projeto:	Americanópolis							
Tipo:	**HIS - Sem varanda**		**HIS - Com varanda**		**HMP - Com varanda**		**R2V - Com varanda**	
Método	**Vision**		**Vision**		**Vision**		**Vision**	
Avaliação	260.000		280.000		300.000		300.000	
Renda Inicial (VF)	3.693		4.199		5.519		5.689	
Renda Final*	-		-		-		-	
% RET1	25%		0%		0%		0%	
Tipo:	**VF**	**R$**	**VF**	**R$**	**VF**	**R$**	**VF**	**R$**
Ato	0,74	2.767	0,66	2.797	0,53	2.937	0,69	3.946
FGTS	1,05	3.906	0,93	3.917	1,06	5.902	1,04	5.942
Financiamento	100,36%	188.670	97,08%	194.591	98,24%	218.490	97,76%	225.436
Subsídio	154,47%	3.582	85,73%	1.852	0,00%	0	0,00%	0
Prazo de Pró-soluto	27	27	27	27	27	27	27	27
Pró-Soluto	90,19%	32.676	90,19%	37.153	68,09%	36.863	70,10%	39.122
Preço Raso (RS)	231.601	231.601	240.311	240.311	264.192	264.192	274.446	274.446
TCD	9,13%	3.398	32,62%	13.808	24,82%	13.808	24,08%	13.808
VSO	20	20	3	3	8	8	7	7
Preço de Venda	**233.057**	**233.057**	**252.019**	**252.019**	**275.702**	**275.702**	**285.872**	**285.872**
Elasticidade	0,833%	0,833%	0,833%	0,833%	0,833%	0,833%	0,833%	0,833%
Preço de Venda Final	**234.999**	**234.999**	**254.119**	**254.119**	**278.000**	**278.000**	**288.254**	**288.254**
Preço Raso (R$)	**231.601**		**240.311**		**264.192**		**274.446**	
% de Raso	**98,55%**		**94,57%**		**95,03%**		**95,21%**	
BP25 - Não Inflacionado	-		-		-		-	
BP25 - Inflacionado	-		-		-		-	

Análise de Preço

Informações Viabilidade

Projeto:	Americanópolis
Tipo:	**Faixa 2**
Método	**Vision**
Avaliação	277.595
Renda Inicial (VF)	4.495
Renda Final*	-

Tipo:	VF	R$
Ato	0,68	3.028
FGTS	1,04	4.711
Financiamento	99,15%	202.366
Subsídio	87,22%	2.011
Prazo de Pró-soluto	27	27
Pró-Soluto	81,76%	35.142
Preço Raso (RS)	247.258	247.258
TCD	17,17%	8.404
VSO	38	38
Preço de Venda	**253.532**	**253.532**
Elasticidade	0,833%	0,833%
Preço de Venda Final	**255.663**	**255.663**
Preço Raso (R$)	**247.258**	
% de Raso	**96,71%**	

1

Análise de Riscos	Farol IM
IM avalia o Preço Vision como **factível**.	

- I.M está de acordo com o preço Vision, tendo em vista que, o projeto está em uma região com bons indicadores sociodemográficos, como renda e PEA/Dia, o mesmo também se encontra próximo de pontos de interesses como hospital, escola e etc.

  Conforme apresentado no slide "Panorama de Concorrência", os empreendimentos da Plano & Plano praticaram preços e rendas abaixo do previsto no parecer, porém tiveram um alto volume de vendas. Dessa forma, o preço estimado para o projeto Americanópolis está confortável, considerando que o VSO projetado é menor.

	Preço Real					Preço Normalizado (27m)	
	Avaliação	Preço Raso	Renda Média	VSO	PSOL	Δ PSOL	Preço Raso
Vista Granja Julieta	**282.968**	**246.582**	**6.000**	**18**	**10**	**17.731**	**264.313**
Vista Vila das Belezas	**240.937**	**226.368**	**4.200**	**32**	**26**	**1.225**	**227.593**
Americanópolis	**277.595**	**247.258**	**4.495**	**38**	**27**	**-**	**247.258**

Ciclo Financeiro – Análise Mancha

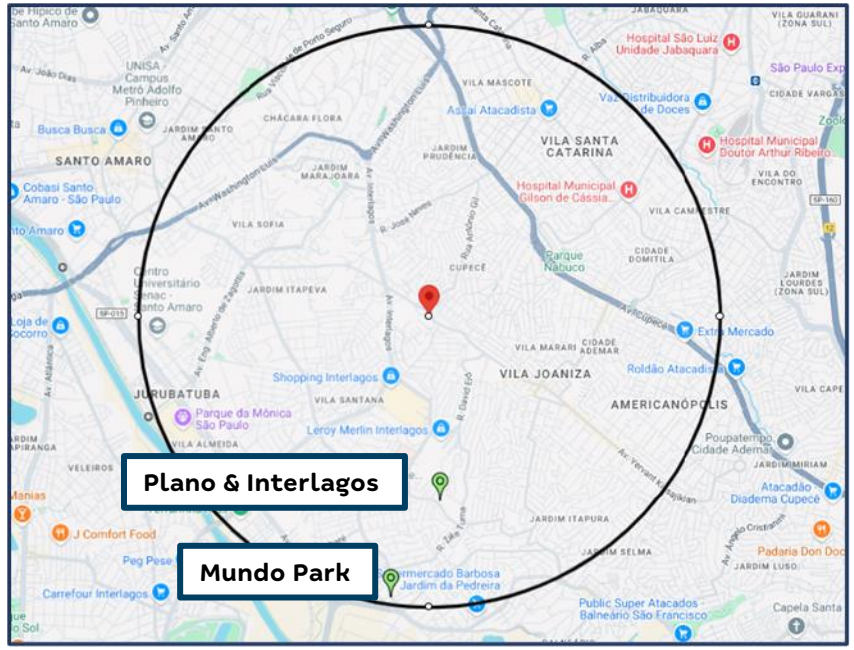

Parecer Ciclo

O Ciclo avaliou Preço e VSO como factíveis. O projeto está em uma região estratégica e de grande potencial, mesmo com o panorama de concorrência atual. A Plano lançou com alto volume em razão das unidades HIS. Mundo Park lançamento recente com volume positivo nas unidades com varandas.

Pareceres

Análise da Mancha e Implantação

Prospecção

Operações

Incorporação

Inteligência de Mercado

Financeiro

Anexos

Informações Financeiras

Americanópolis - SP - São Paulo Capital

Datas e Prazos

	Compra	Lançamento	Início Obra	Término Obra	LÇTO até IO	IO até TO	Chaves	LÇTO até Chaves
Consolidado	dez-25							
Americanópolis HMP c varanda		ago-27	fev-28	dez-29	6 meses	22 meses	ago-30	36 meses
Americanópolis HIS c varanda		ago-27	fev-28	dez-29	6 meses	22 meses	ago-30	36 meses
Americanópolis HIS s varanda		ago-27	fev-28	dez-29	6 meses	22 meses	ago-30	36 meses
Americanópolis HIS c varanda		ago-27	fev-28	dez-29	6 meses	22 meses	ago-30	36 meses

Terreno e Incorridos

TOTAL (R$ + Perm.):	23,00 MM	**Incorrido Terreno:** 0,00 MM	**Área do Terreno (100%):**	5.241 m²	**Área Líquida do Terreno:** 4.362 m²
Cash:	23,00 MM		**Custo de terreno m²:**	4.388,1	**Custo de terreno m² Área Líquida:** 5.272,8
Permuta Financeira:	0,00 MM (0,00%)		**VaR 25 (R$ mil):**	0	**Fração Terreno/Terreno + Custo Obra (%VGV):** 12,7% / 51,6%
Permuta Física:	0,00 MM (0,00%)		**VaR 26 (R$ mil):**	0	**CA Máx/Proj.** 10,2 / 4,3
Ato / %VGV:	0,70 MM / 0,4%		**Incorrido de Construção:**	0,00 MM	**Incorridos de Incorporação:** 0,00 MM

Vendas

Fases	Nº Pavimentos	Preço Raso Unit.	Qtde	Preço Unit.	Aval. CEF	Cond. Parcela	% Pró-soluto	% TCD
Americanópolis HMP c varanda	T+17	274.484	134	288.254	300.000	97,8%	70,1%	24,1%
Americanópolis HIS c varanda	T+17	264.199	148	278.000	300.000	98,2%	68,1%	24,8%
Americanópolis HIS s varanda	T+17	231.600	367	234.999	260.000	100,4%	90,2%	9,1%
Americanópolis HIS c varanda	T+17	240.325	58	254.119	280.000	97,1%	90,2%	32,6%

Unidades Totais:	707	**Preço Médio:**	255.663	**Renda Média:**	4.495	**ITBI+Emol. Unit. Médio:**	5.451
Unidades Tenda:	707	**Avaliação Média:**	277.595	**Ato:**	3.057 (0,68 Salários)	**Custo do Ciclo Unit.:**	16.094
VSO:	39 Unidades	**VGV Total:**	180.753.549	**FGTS:**	4.676 (1,04 Salários)	**Preço Raso Médio:**	247.267
RET Médio:	3,6%	**VGV Tenda:**	180.753.549	**% em RET 1%:**	13%	**Adc. Tx. de Aceleração Médio:**	750

Construção

Custo Total Unit. | Corrigido:	99.269 | 99.781	**Eventuais:**	4,00%	**Área priv (m²):**	31,86	**Gape / Mês Unit.:**	11,08

Resultado

LI (R$):	**20.312.881**	**LI:**	**20,01%**	**Exposição de Caixa (R$):**	**22.564.603**	**Margem Bruta Econômica:**	**37,73%**
TIR:	**104,02%**	**LI Aprovação:**	**20,00%**	**Ger. Caixa 12 meses (R$):**	**(785.426)**	**Margem Bruta REF:**	**41,84%**
Exposição de Caixa:	**11,39%**	**Δ LI:**	**0,01%**	**Ger. Caixa 24 meses (R$):**	**(1.137.351)**	**Margem Rasa Econômica:**	**35,33%**
Payback Contingente (21 m):	**19 m/ (-2 m)**	**LI Resiliência:**	**11,73%**	**Ger. Caixa Marginal (R$):**	**47.121.342**	**Margem Rasa REF:**	**39,87%**
Payback Consolidado:	**19 meses**					**Margem de Contribuição Econômica:**	**25,94%**

Informações Financeiras

R$ Mil - Valores Nominais - Compra	Americanópolis	
	Nominal	%
Receita	198.109	100,0%
PIS/COFINS	(3.957)	2,0%
Custo Total	(120.899)	62,3%
Custo Terreno	(26.571)	13,7%
Custo Relacionados a Terreno	(2.034)	1,0%
Custos de Incorporação	(3.487)	1,8%
Custo de Construção	(88.807)	45,7%
Lucro Bruto Econômico	73.252	37,7%
Custo para Rateio	-	0,0%
Lucro Bruto Contábil	73.252	37,7%
Despesas de Selling	(18.337)	9,4%
Contingência	(4.557)	2,3%
Margem de Contribuição	50.359	25,9%
IR e CSLL	(3.238)	1,6%
Margem Líquida	47.121	24,3%
Lucro Bruto REF Unit.	121.821	41,8%
Lucro Raso REF Unit.	112.252	39,9%

R$ Mil - VPL - Compra	Americanópolis	
	VP	%
Receitas	101.521	100,0%
PIS/COFINS	(1.995)	2,0%
Custos e Despesas Totais	(79.213)	78,0%
Custo Terreno	(14.927)	14,7%
Custo Relacionados a Terreno	(1.353)	1,3%
Custos de Incorporação	(1.990)	2,0%
Custo de Construção	(47.275)	46,6%
Despesas de Selling	(10.863)	10,7%
Contingência	(1.171)	1,2%
IR e CSLL	(1.632)	1,6%
Lucro Imobiliário	20.313	20,0%

Pareceres

Análise da Mancha e Implantação

Prospecção

Operações

Incorporação

Inteligência de Mercado

Financeiro

Anexos

AMBIENTAL + LEGALIZAÇÃO – Paramétrico de custos

DADOS	
Quantidade de unidades	707
O Empreendimento terá R2V?	NÃO
Qual a área do Terreno?	5.241
Quanto % do terreno Possui árvore?	15%
Possível Área Contaminada?	SIM
Esta Cadastrado como Área Possivelmente Contaminada nos Orgão Publicos?	NÃO
Parcelamento do Solo?	NÃO
Quantos Condomínios?	1

ABERTURA	$ FINAL		MÉTRICA
Compensação Ambiental	R$	222.725	média histórica/ m² de terreno + acrescimo de 30% do valor com aplicação de R2V
Laudos, EIV, EIARIMA	R$	15.000	15k fixo
Emolumentos e Taxas	R$	35.000	5k - Revalidação de Certidões + 30k aprovação CETESB (contaminação) quando for classificado como potencialmente contaminado ou existir a possibilidade de ter contaminação;
Assessorias	R$	5.000	Custas second opinion Ambiental
Cópias, Plotagens, Autenticações, etc...	R$	15.000	15k fixo
Contra Partida	R$	349.146	Não temos contrapartida para SP Capital Considerado custas de contaminação/ remediação histórica dos empreendimentos em LB/ m² de terreno
Projeto de criação e Legal	R$	10.500	1.5k/condomínio de tercerização PL + 4k/condomínio de NBR + 5k complemento plani + 15k para parcelamento do solo (quando houver) + 3.5k para pl grapro (quando houver)
Total	**R$**	**652.370**	**R$ 923/uh**

JURÍDICO – Paramétrico de custos

DADOS	
Quantidade Unidades	707
Área Construída	28.103 m²
Tem SQL?	SIM
Valor do carne de IPTU	R$ 97.232
Área de Matrícula	5.241
Retificação?	SIM
Quantos Condomínios?	1
Quantos Proprietários de terreno?	1
Parcelamento do Solo?	NÃO
Remembramento de Matrículas?	NÃO
Com qual valor o terreno será escriturado?	R$ 23.000.000

ABERTURA	$ FINAL		MÉTRICA
Desdobro de IPTU	R$	2.500	R$ 2.5k/ condomínio
Instituição de Condomínio	R$	883.750	R$ 1250/uh
Averbação da Construção	R$	212.461	Área Construída(m²) X 4 meses de Cobrança X Índice Histórico (atual 1,79/m²)
Procuração Societária	R$	5.000	5k fixo
IPTU (Anual)	R$	97.232	Valor do caner vigente de IPTU ou em caso de não tenha IPTU, considerado para calculo área da matrícula X Índice Histórico (atual 1,79/m²)
Registro de Incorporação	R$	248.470	R$ 210/uh + 40k quando houver necessidade de retificação
Honorário Incorporação	R$	-	Não gastamos mais com honorários de incorporação Considerado IPTU Retroativo por não ter SQL: $ IPTU X 5 anos
Cópias e Autenticações	R$	15.000	15k fixo
Honorário Aquisição	R$	80.000	120k - 2 ou mais prorietários do terreno 80k - 1 proprietário do terreno
ITBI Terreno	R$	690.000	Valor do terreno X 3%
Total	**R$**	**2.234.413**	**R$ 3.160/uh**

Comentários Jurídicos – Ajustes após validação do Jurídico.

Instituição de Cond.: R$ 857.763,11
Averbação da Construção: R$ 201.217,48
Registro de Incorporação: R$ 153.397,86 +R$ 40.000,00
Honorários Aquisição: R$ 120.000,00
Escritura e Registro: R$ 86.000,00 +R$ 24.000 + R$5.000

Valor total estimado: R$ 2.297.110,45

CRONOGRAMA PRÉVIO – Prazos de aprovação

APROVAÇÃO DE CONDOMÍNIO
TERRENO <20.000
DISPENSA GRAPROHAB <800UH (Ñ CONTÍGUO)
COM ÁREA CONTAMINADA
IPHAN – Ñ SE APLICA
COM RETIFICAÇÃO

PRAZO
20 meses

CIE CIA L

MÊS	RESP	ETAPA	INÍCIO	FIM	STATUS/ PRAZO (dias)	-6	-5	-4	-3	-2	-1	0	1	2	3	4	5	6	7	8	9	10	11	12	13	14	15	16	17	18	19	20
0	**PROSP**	**COMITÊ INVESTIMENTO ESSENCIAL**	**16/6/25**	**16/6/25**	**-**																											
	NEG	REUNIÃO PASSAGEM/ PARTIDA	23/6/25	23/6/25	-																											
	NEG	PLANIALTIMÉTRICO	28/6/25	2/8/25	35																											
	JRI	MATERIAL RETIFICAÇÃO	7/8/25	6/10/25	60																											
	JRI	RETIFICAÇÃO MATRICULA	6/10/25	3/6/26	240																											
	NEG	DIRETRIZ SABESP	8/7/25	22/8/25	45																											
	PRÉ-LEG	INVESTIGAÇÃO AMBIENTAL	3/7/25	31/10/25	120																											
	DPP	ELABORAÇÃO AP	17/8/25	6/9/25	20																											
	CUSTOS	PARAMETRIZAÇÃO	21/9/25	11/10/25	20																											
	NEG	CONFIRMAÇÃO FINANCEIRA	5/11/25	15/11/25	10																											
6	**NEG**	**COMITÊ INVESTIMENTO AMPLIADO**	**20/12/25**	**20/12/25**	**-**																											
	GETEC	ENGENHARIA SIMULTÂNEA	26/10/25	10/12/25	45																											
	GETEC	ELABORAÇÃO PROJETO SABESP	13/9/25	11/1/26	120																											
	GETEC	APROVAÇÃO SABESP	18/1/26	18/5/26	120																											
	GETEC	EP KIT LEGAL	11/12/25	16/4/26	126																											
	PL	ELABORAÇÃO PL	16/9/25	31/10/25	45																											
	LEG	CETESB (CONTAMINADO)	15/11/25	14/5/26	180																											
	LEG	ALVARÁ DE APROVAÇÃO E EXECUÇÃO	7/11/25	7/11/26	365																											
	LEG	DISPENSA DE GRAPROHAB	8/9/26	28/9/26	20																											
	NEG	**COMITÊ DE ESCRITURA/ LANÇAMENTO**	**14/11/26**	**14/11/26**	-																											
	JRI	ESCRITURA	27/11/26	27/12/26	30																											
	JRI	REGISTRO INCORPORAÇÃO	28/12/26	27/1/27	30																											
	CRD	LAUDOS CEF	10/11/26	8/2/27	90																											
20	**NEG**	**LANÇAMENTO**	**8/2/27**	**8/2/27**	**-**																											

PARECER PRÉVIO – Jurídico Imobiliário

- **DESCRIÇÃO DO IMÓVEL:** Matrícula nº 263.913 do 11º Oficial de Registro de Imóveis de São Paulo/SP ("Imóvel"), localizado na Avenida Yervant Kissajikian, nº 416-A, Cidade Ademar, São Paulo/SP. Cadastro Municipal nº 120.078.0181-6.

- **PROPRIETÁRIOS TABULARES:** CLEMONCITY SOCIEDAD ANONIMA ("CLEMONCITY").

- **CONSIDERAÇÕES JURÍDICAS SOBRE O IMÓVEL: (a) Retificação:** Será analisado em estudos técnicos; **(b) Loteamento:** Da análise da matrícula do Imóvel, verifica-se que a área é um lote integrante do loteamento "sem denominação especial", registrado sob o nº 01, em 06/07/1994, na Matrícula nº 262.844 do 11º Oficial de Registro de Imóveis de São Paulo, processo nº 2.192 ("Loteamento 1994"), denominado de Lote nº 03. Da análise dos documentos recebidos relativos ao Loteamento 1994, quais sejam, o seu memorial descritivo e o traslado da escritura pela qual o loteador alienou o lote ao primeiro adquirente, e não identificamos quaisquer restrições convencionais de loteamento, com exceção da indicação da área *non aedificandi*, nos termos a seguir detalhado. Ainda, nos termos da nota devolutiva do 11º Oficial de Registro de Imóveis de São Paulo, destacamos que não foi identificado, por tal serventia, o arquivamento de contrato padrão de alienação dos lotes do Loteamento 1994. Ainda, identificamos na margem da cadeia de filiação até a origem do Imóvel, exclusivamente perante o 11º Oficial de Registro de Imóveis de São Paulo, a Inscrição nº 102, do Livro 08-A de Registro Especial, de 04/11/1953, indicando a existência de um memorial depositado em tal cartório pelo Consórcio Nacional de Terrenos S/A, referente ao loteamento denominado "Jardim Consórcio", com a área total de 408.130,000m², no 30º Subdistrito - Santo Amaro, cujo processo de loteamento encontra-se arquivado em tal serventia sob o número de ordem 102 ("Loteamento 1953" que, em conjunto com o Loteamento 1994 serão simplesmente denominados de "Loteamentos"). Necessário os estudos técnicos; **(c) Área construída**: área construída de 319,00m² (trezentos e dezenove metros quadrados); **(d) Débitos Imobiliários**: R$ 1.622.535,12 correspondentes a dívida ativa e R$ R$105.081,74 correspondente a parcelas vencidas e vincendas do atual exercício; **(e) Multas:** Identificadas 10 multas, sendo 07 multas no status em aberto, 01 negada em juízo e 02 multas com PPI homologado, no valor total atualizado de **R$ 690.922,79** (data base de 28/01/2022) **(f) Ônus e Gravames**: Será analisado em renovação de Due Diligence; **(g) Ocupação**: O imóvel esta invadido e o proprietário é o responsável por entregar o imóvel livre de pessoas, conforme ação de despejo em andamento pela qual aguarda-se o cumprimento do mandado pelo Oficial de Justiça; **(h) TAC:** Será analisado se haverá necessidade de TAC em renovação de Due Diligence com área de LEG; **(i) CONDEPHAAT, CONPRESP, IPHAN:** Será analisado em renovação de Due Diligence; **(j) Desapropriação e Melhoramentos:** Será analisado em renovação de Due Diligence e **(k) Função Social da Propriedade:** O imóvel está invadido e já existe uma ação de despejo em andamento.

PARECER PRÉVIO – Jurídico Imobiliário

- **CONSIDERAÇÕES PRELIMINARES SOBRE OS PROPRIETÁRIOS:**
- **A) CLEMONCITY SOCIEDAD ANONIMA.:**
  - Processos TJSP: A proprietária possui aproximadamente R$ 1.400.000,00 em processos na esfera cível
  - Processos TRF Cível: Aproximadamente R$ 400.000,00 em processo.
  - CND Tributos Mobiliários:. Positiva.
  - Empresa domiciliada no exterior – Montevideo/Uruguai.

- **CONCLUSÃO.:** A presente análise corresponde aos apontamentos em nome do proprietário tabular, não possuindo ações de valores relevantes comparado ao valor da aquisição que é de R$ 23.000.000,00 (vinte e três milhões de reais). Ponto de atenção importante é a desocupação do imóvel, tendo em vista que o mesmo se encontra invadido, sendo de responsabilidade do vendedor a desocupação.
- De acordo com a DD prévia entendemos ser viável darmos andamento aos próximos atos a serem praticados para a efetiva aquisição do terreno e que na DD detalhada em conjunto com estudo jurídico e técnico teremos maiores informações sobre o imóvel e proprietários

LEGALIZAÇÃO

➢ ÁREA DE IMPLANTAÇÃO

- O terreno é composto por 1 matrícula 263.913 CRI, em nome de pessoa jurídica, que totaliza uma área escriturária de 5.241,44m²;
- O cadastro do imóvel é urbano;
- O cenário foi desenvolvido sobre a poligonal do MDC definida 5.242,00m²;
- Rua Conforme BDT nº 2025-107607-00, AV YERVANT KISSAJIKIAN Largura da via 13,90m

➢ DIRETRIZES URBANÍSTICAS

- O terreno esta inserido em ZEIS-3, conforme decreto 63.728/2024:
  - C.A. máximo: 4 , para EHMP, e TO 0,70% e PA7, necessário reserva de calçada.
- Terreno será não parcelado (sem exigência de doação de areas publicas);
- O estudo considera implantação de 1 condomínio, sendo:

  Torre 1 x 20PP x T+17 e, com 353 UH

  Torre 2 x 20PP x T+17 e, com 354 UH

  CA MÁX- PROJETADO 4,00

  INCENTIVO 50% his2 NÃO COMPUTAVEL 0,30
- A legislação não exige vaga de garagem, cenário considera 1 vaga PNE;
- Usos permitidos: EHIS e EHMP.

➢ GRAPROHAB

- Numero de UH do estudo EM não supera o 800 UH, não sendo necessário a aprovação;

LEGALIZAÇÃO

➢ AVALIAÇÕES AMBIENTAIS

Arbóreo

- Conforme mapa vegetação 1988 o terreno **não** é considerado como Patrimônio Ambiental
- Não incide sobre o terreno APP;
- Para cenário de comitê, conforme parametrização enviada, foi considerado 15% de incidência arbórea.
- A propriedade não está inserida em Área de Patrimônio Ambiental (APA), Área de Proteção de Mananciais (APRM) e Unidade de Conservação;

Hidrografia

- O Imóvel apresenta corpos d'água ao perímetro ou próximo;
- Córrego mais próximo Córrego zevuvus localizado na parte de trás do imóvel(córrego canalizado);

➢ AVALIAÇÕES AMBIENTAIS

Contaminação (Contaminado)

1 – Conforme BDT o imóvel não é cadastrado perante a municipalidade;

Para efeito de comitê essencial foi considerado o terreno como contaminado, pois o terreno está sendo utilizado em parte como um estacionamento

LEGALIZAÇÃO

- **ÓRGÃOS DE PATRIMÔNIO HISTÓRICO**

- De acordo com a certidão CIT, o imóvel é isento de aprovação perante ao CONPRESP, CONDEPHAAT, UPPH e DPH;

- **URBANIZAÇÃO**

- Não consta DUP/DIS ou ação visando a desapropriação do imóvel, o mesmo é atingido por plano de melhoramento viário ou sanitários;
- Conforme croqui patrimonial, não consta área pública no imóvel;

- **OUTROS ITENS NECESSÁRIOS/ESPECÍFICOS**

- No BDT foi identificado um melhoramento viário que não consta no geosampa, estamos aguardando a certidão

Obrigado