Tenda

sua próxima conquista

Book de Investimento

Regional: CPS

Projeto: Furacão

Data Comitê: 23/06/2025

Comitê Digital 23/06/2025

Nome	Furacão 2000 - Investimento	Observação - Furação 2000
Andre Luis Menegazzo Padilha	Aprovado	ok
Alexandre Regis de Oliveira	Aprovado	Ok
Renan Barbosa Sanches	Discutir em Comitê	Podemos melhorar a área de lazer adicionando piscina e quadra dentre outros atributos? Não temos mix de varanda aqui?
Alejandro Octavio Abiusi	Aprovado	De acordo com a baixa contabilizando 50% das unidades.
Fabricio Quesiti Arrivabene	Discutir em Comitê	Preocupação com o preço, dado que LI não está fechando
Luiz Mauricio de Garcia Paula	Discutir em Comitê	não consegui conciliar toda a diferença entre o valor a ser pago aos proprietários do terreno (R$9 milhões) com o valor total atribuído ao terreno (R$11,5 milhões)?
Amanda da Silva Bezerra	Aprovado	Ok
Rodrigo Osmo	Discutir em Comitê	(1) Qual é nossa tese para o Parque Quaresmeira estar performando um VSO inferior ao projeto equivalente da MRV?

Questionamentos – Fabrício Arrivabene

"Preocupação com preço, dado que LI não está fechando."

A macro e microrregião são consideravelmente melhores que o projeto que estamos comercializando hoje (Portal das Quaresmeiras), e conforme demonstrado na tabela de preços, a concorrência pratica preços superiores ao estimado para o Furacão.
Com a nova tipologia, viabilização do deck park e inclusão de atributos de lazer, aumentaremos a quantidade de unidades para utilizar todo o coeficiente de aproveitamento diluindo custos (terreno por exemplo é valor fixo), atingindo os 20% de LI

Questionamentos – Luiz Mauricio

"Não consegui conciliar toda a diferença entre o valor a ser pago aos proprietários do terreno (R$9 milhões) com o valor total atribuído ao terreno (R$11,5 milhões)"

Para aprovação via COHAB, é necessária a doação de 2% das unidades totais como contrapartida; neste empreendimento são 11 unidades de contrapartida (R$ 2,57MM) – no modelo da viabilidade de Campinas esta doação entra como custo de terreno em permuta física.

Questionamentos – Renan Barbosa Sanches

“Podemos melhorar a área de lazer adicionando piscina e quadra dentre outros atributos? Não temos mix de varanda aqui?”

Sim, com a nova tipologia e novo gabarito, traremos melhoria de lazer, mix de varanda e deck park, inclusive para atingirmos a régua de LI; estes pontos serão tratados na etapa de desenvolvimento do projeto.

Questionamentos – Rodrigo Osmo

“(1) Qual é nossa tese para o Parque Quaresmeiras estar performando um VSO inferior ao projeto equivalente da MRV?”

"Retomamos a operação em Campinas em 2025 com a abertura de um PDV 100% EV e com estrutura de Tenda Vendas. Considerando termos apenas um projeto em comercialização na praça optamos por não estruturar a equipe com CLTs.
Em março de 2025, as vendas do Módulo II foram temporariamente bloqueadas devido à mudança no sistema construtivo, o que exigiu a recontratação junto à CEF. Com isso, foi necessário realizar as trocas das unidades vendidas do módulo II para o módulo I, reduzindo nosso estoque de unidades sem vaga e limitando a possibilidade de maiores volumes de venda. A liberação do Módulo II está prevista para julho.
Em contraponto MRV é o maior player de MCMV em Campinas e conta com uma super estrutura."

One Page Furacão - Aprovação

Cidade	Campinas	**Mancha de demanda**	CPS - CP - Campinas
Regional	CPS	**Cluster MPR**	2 - Amarelo
Cenário de Aprovação	Aprovação	**Tipo de Aprovação**	Consolidado
Fase Anterior	N/A		
Tipo de Comitê	Investimento	**Versão da VF**	Versão 1.0: Jun

Unidades (% Vagas)	537 (55%)	**CA Máx | Proj**	3,0 | 2,0
Tipologia	F2E - Concreto	**Escritura**	fev-27
Fases	1 fases	**Lçto | Duração (m)**	mar/27 | 25

Valor Líquido do Terreno (% VGV)	11.567 (9,2%)	**Un. Perm. Fís (% Ter)**	11 (22,2%)
Cash (Correção)	9.000 (Preencher)	**%VGV Perm Fin Líquida (% Ter)**	0,0% (0,0%)
Valor R$/m²	1.128	**VAR (%VGV)**	000 (0,0%)

Custo Construção (%VGV)	56.271 (44,8%)	**Indireto Unit.**	18.873
Prazo da Obra (meses)	19	**Torre Unit.**	59.637
Custo Total Unit. | Corrigido (LPU):	104.788 | 104.193 (91)	**Infra Unit.**	14.403
Início de Obra	set-27	**Fundação Unit.**	7.547

Preço Nominal Unit.	233.927	**VSO**	29
Preço Raso Unit.	210.192	**Referência**	Vision
Avaliação Unit.	244.855	**Renda (% em RET 1%)**	3.377 (37,4%)

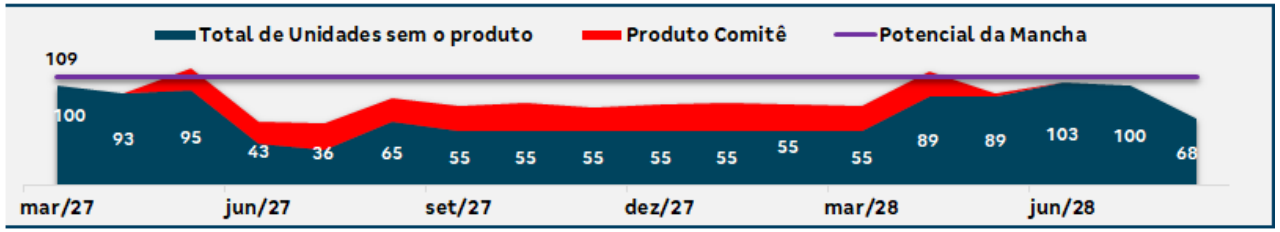

LI (Régua):	**17,7% (20,0%)**	**Margem Bruta Econômica:**	36,7%
LI Resiliência:	9,4% (N/A)	**Margem Rasa Econômica:**	28,9%
Margem Bruta REF:	40,1%	**Margem Contribuição Econômica:**	25,6%
Margem Rasa REF:	**33,4%**	**Exposição (% VGV):**	17.934 (13,1%)
TIR:	101,9%	**VGV Total:**	125.619
Payback Contingente (21 m) :	**20 m/ (-1 m)**	**Ger. Caixa 12 meses (R$):**	-
Payback Consolidado:	20	**Ger. Caixa 24 meses (R$):**	(3.508)

Destaques

[1] Produto: Destaque por tratar-se de um Terreno já loteado com 10.250,95m², com 537 UH divididas em 3 torres (10PP/12PP/12PP e T+15/T+15/T+15) e 291 vagas de garagem comercializáveis, utilizando a tipologia atualmente disponível para a regional de T+15 e máximo de 14PP. Região superior ao empreendimento em andamento na regional (Portal dos Quaresmeiras), sendo que atualmente temos empreendimentos da Direcional e MRV sendo comercializados com ticket médio nominal superior a 300k..

[2] Condição Comercial: Compra com valor de R$9.000.000,00 pago em 24 parcelas iniciando após conclusão da análise técnica (16 meses). Valor corrido pelo IPCA – (Correção se inicia após o pagamento da primeira parcela, que será efetivada na escritura);

[3] Possíveis ganhos:
Expectativa de atingimento da LI 20%: este terreno possui um Coeficiente de Aproveitamento (CA) máximo de 3, sendo o projetado atualmente de 2,03. No entanto, devido à obrigatoriedade de destinar 50% das vagas para este zoneamento, não é possível atingir o CA máximo permitido. Com base em estudos realizados, já considerando a tipologia mais otimizada e de maior gabarito (T+18) em desenvolvimento para Campinas e a inclusão de um Edifício Garagem, estima-se um **ganho potencial de 341 unidades habitacionais (UH)**, totalizando 878 UH — um acréscimo de aproximadamente 64% no número de unidades do empreendimento e que viabilizaria o custo adicional do Edifício Garagem. Além disto, a negociação estabeleceu valor fixo, ou seja, não há participação dos proprietários nesses ganhos.

[4] Legalização: O terreno é um lote regular(processo mais rápido), mas deverá passar por Graprohab antes da aprovação do empreendimento, para alteração do uso do lote junto ao estado uma vez que o loteamento foi aprovado com uso comercial – esta etapa de mudança está considerada no cronograma de aprovação e foi viabilizado nas tratativas e consultas já realizadas com Prefeitura e Graprohab.

*Valores em R$ '000

- Pareceres
- Análise da Mancha e Implantação
- Prospecção
- Operações
- Inteligência de Mercado
- Financeiro

Farol – Pareceres

Área	Riscos Associados	Parecer	Criticidade
Jurídico	O presente parecer foi elaborado com base na Due Diligence realizada em 12/09/2024. Diante disso, entendemos ser viável o prosseguimento dos próximos atos, ressalvando que, na ocasião da renovação da Due Diligence detalhada, teremos acesso a informações mais atualizadas sobre o imóvel e seus proprietários.	Ok com ressalvas	
Legalização	O loteamento foi aprovado estritamente como comercial. Em consulta à Prefeitura, foi informado que não há óbices, uma vez que o zoneamento atual permite a construção de empreendimento residencial. Entretanto, com relação ao Graprohab, foi informado que mesmo o loteamento já se encontrando implantado, será necessário passar por aprovação do órgão para reemissão das licenças ambientais considerando o uso residencial. Necessário aprofundar o assunto já que esse licenciamento é completamente atípico. Necessário verificar se será necessário aprovar o projeto no COMAER, já que o terreno se encontra a 4km do Aeroporto de Viracopos. O terreno se encontra dentro do raio de 2km do Vila Abaeté, sobre o qual recai uma Ação Civil Pública, ainda sem trânsito em julgado. Outros empreendedores estão incorporando na região sem enfrentar qualquer problema, porém a COHAB/PMC solicita o preenchimento de uma Declaração de Ciência, pois caso a ação seja julgada durante o período da legalização até o momento do habite-se, podemos enfrentar entraves no licenciamento. Considerado baixo risco, uma vez que os lotes em estudo são oriundos de um parcelamento regular.	Ok com ressalvas	
Produto	Sem riscos associados	Ok	
GETEC	As diretrizes da SANASA encontram-se vencidas, sendo necessária revalidação	Ok com ressalvas	
Logística	Sem riscos associados	Ok	
Contratação	N/A	Ok	
Inteligência de mercado	IM avalia o Preço Vision como factível, porém, com ressalvas para o VSO.	Ok com ressalvas	
Comercial/Ciclo	N/A	Ok	
Estudos Econômicos	Ok, caso o projeto seja aprovado deverá ser considerado 50% para meta.	Ok com ressalvas	

- **DESCRIÇÃO DOS IMÓVEIS:** Matrículas n.ºs 252.106 ("**Imóvel I**") e 252.107 ("**Imóvel II**"), ambas do 3º RI de Campinas/SP, designados como Lote 6 e Lote 7 da Quadra A do Centro Logístico de Viracopos, e ambos cadastrados perante a Prefeitura de Campinas sob o código cartográfico n.º 3451.53.75.0001.00000 (em maior área).

- **PROPRIETÁRIA**: WEP COMÉRCIO E LOCAÇÃO DE IMÓVEIS LTDA. (Loteadora)

- **DA CONSULTA AO CADASTRO NACIONAL DE EMPRESAS INIDÔNEAS E SUSPENSAS (CEIS) e CAIXA AQUI:** Não é objeto de análise pelo NFA.

- **CONSIDERAÇÕES JURÍDICAS SOBRE O IMÓVEL**: conforme os relatórios dos Estudos Jurídicos emitidos pelo NFA Advogados, datados de 14/05/2024 e 24/09/2024, e Estudos Técnicos emitido pela Zenith, em 06/03/2024, foram apontadas, em suma, as seguintes considerações: **(a) Retificação: (i) Imóvel I:** no comparativo entre a área física e registraria do **Imóvel I**, verificou-se que as divisas propostas respeitam os limites dos logradouros confinantes e dos imóveis lindeiros. Assim, a Zenith concluiu que foram respeitadas todas as medidas e área narradas na matrícula, não existindo a necessidade de correção de sua descrição tabular; **(ii) Imóvel II:** a descrição registrária do Imóvel II preenche os requisitos previstos no art. 176, parágrafo 1º, inciso II, item "3", alínea "b", da Lei de Registros Públicos, pois há encerramento de área, indicação das medidas perimetrais e referência ao logradouro/localização e às confrontações. No entanto, o comparativo entre as áreas física e registrária é objeto do estudo técnico, em elaboração pela empresa Zenith e, até o momento de elaboração dos Estudos Jurídicos da referida área, não foi recepcionada a documentação para análise; **(b) Loteamento**: os Imóveis integram Loteamento "Centro Logístico Viracopos", registrado na matrícula 150.308 sob n.º 27, com destinação comercial/industrial, conforme documentos do licenciamento, o que impossibilita a construção de lotes residenciais, sendo necessário alterar previamente a destinação. Conforme averbações sob n.ºs 31, 32, 33 e 34, foi atestada a execução parcial das obras de infraestrutura do Loteamento, tendo sido emitidos TVOs parciais, bem como tendo sido cancelada parcialmente a garantia hipotecária, a qual não recai sobre os Imóveis; e **(c) Regularidade Ambiental: (i)** multa n.º 211/2019, inscrita em dívida ativa no valor de R$ 3.969,61 (boleto emitido em 23/09/2024) referente a multa pela realização de queimadas, **(ii)** Termo de Compromisso de Recuperação Ambiental (TCRA): obrigação de plantio de mudas em estágio inicial. Conforme averbado sob n.º 35 da Matrícula n.º 150.308, de 04/09/2024, foi emitido pela CETESB a Licença de Operação de Loteamento nº 0500265 (processo 05/00033/19) referente ao loteamento Centro Logístico de Viracopos, devendo serem atendidas todas as observações e prazos mencionados na referida licença.

- **DD IMÓVEIS**: conforme relatórios de DD emitidos pelo NFA Advogados em 07/05/2024 e em 12/09/2024 **(a) Área Construída**: não há. **(b) Débitos Imobiliários**: certidão negativa; **(c) Multas:** ambiental mencionada item "(b.i)" acima; **(d) Ônus e Gravames**: não há. No entanto, necessário confirmar tecnicamente se as áreas de servidão constantes da matrícula de origem foram respeitadas quando do parcelamento; **(e) Ocupação**: desocupado. **(f) TAC**: item "b.(ii)" acima; **(g) CONDEPACC, CONDEPHAAT**: **Imóvel I** - certidão e consultas negativas, **Imóvel II** – certidões por endereço; **(h) IPHAN : Imóvel I e II –** ofícios negativos; **(i) Desapropriação/Melhoramentos: Imóvel I** - certidão negativa, **Imóvel II** – certidões por endereço; **(j) Função Social da Propriedade**: consulta negativa; e **(k) Contas de consumo**: inexistem ligações de água, energia e gás nos Imóveis.

- **CONSIDERAÇÕES SOBRE OS CADASTROS FISCAIS DOS IMÓVEIS NA PREFEITURA:** parte das certidões expedidas pela Municipalidade indicam como contribuinte a numeração do cadastro em área maior (3451.53.75.0001.00000), o qual constou na Opção de Compra, e parte das certidões indicam a numeração individual atribuída ao Imóvel I pela Prefeitura de Campinas (3453.21.97.1053.00000) sem que, no entanto, seja possível emitir a totalidade das certidões do Imóvel para referido contribuinte. Até a presente data não foi concluída a individualização dos cadastros municipais para cada um dos Imóveis. **Recomendação**: a regularização cadastral é condição resolutiva, de modo que foi recomendado que a Proprietária diligencie e comprove a atualização dos cadastros individualizados perante as secretarias municipais, incluindo a secretaria de finanças (o lançamento de IPTU está vinculado ao cadastro da área maior).

- **CONSIDERAÇÕES SOBRE A PROPRIETÁRIA: (i) Passivo:** R$ 122.982,21; e **(ii) Patrimônio:** R$ 6.436.108,47 – suficiente para fazer frente ao passivo apurado. **Recomendação**: quitação dos débitos municipais inscritos em dívida ativa previamente à outorga da EVC, em observância ao artigo 185 do CTN (presunção de fraude à execução em razão da existência de débitos regularmente inscritos em dívida ativa).

- **CONCLUSÃO.:** O presente parecer foi elaborado com base na Due Diligence realizada em 12/09/2024. Diante disso, entendemos ser viável o prosseguimento dos próximos atos, ressalvando que, na ocasião da renovação da Due Diligence detalhada, teremos acesso a informações mais atualizadas sobre o imóvel e seus proprietários.

Pareceres

Análise da Mancha e Implantação

Prospecção

Operações

Inteligência de Mercado

Financeiro

Mancha de Demanda

MANCHAS DE DEMANDA

CPS - Campinas

Lançamento

1. Portal das Quaresmeiras

LandBank

2. Vista Ouro Verde
3. Monte Alto
4. Vista | Vale da Mata
5. Gran Vista
6. Portal Monte Alto
7. Solar das Flores (Abacateiro)
8. Furacão

Cluster MPR – (Comitê)

Cluster 2 - Amarelo

Região

Região Metropolitana

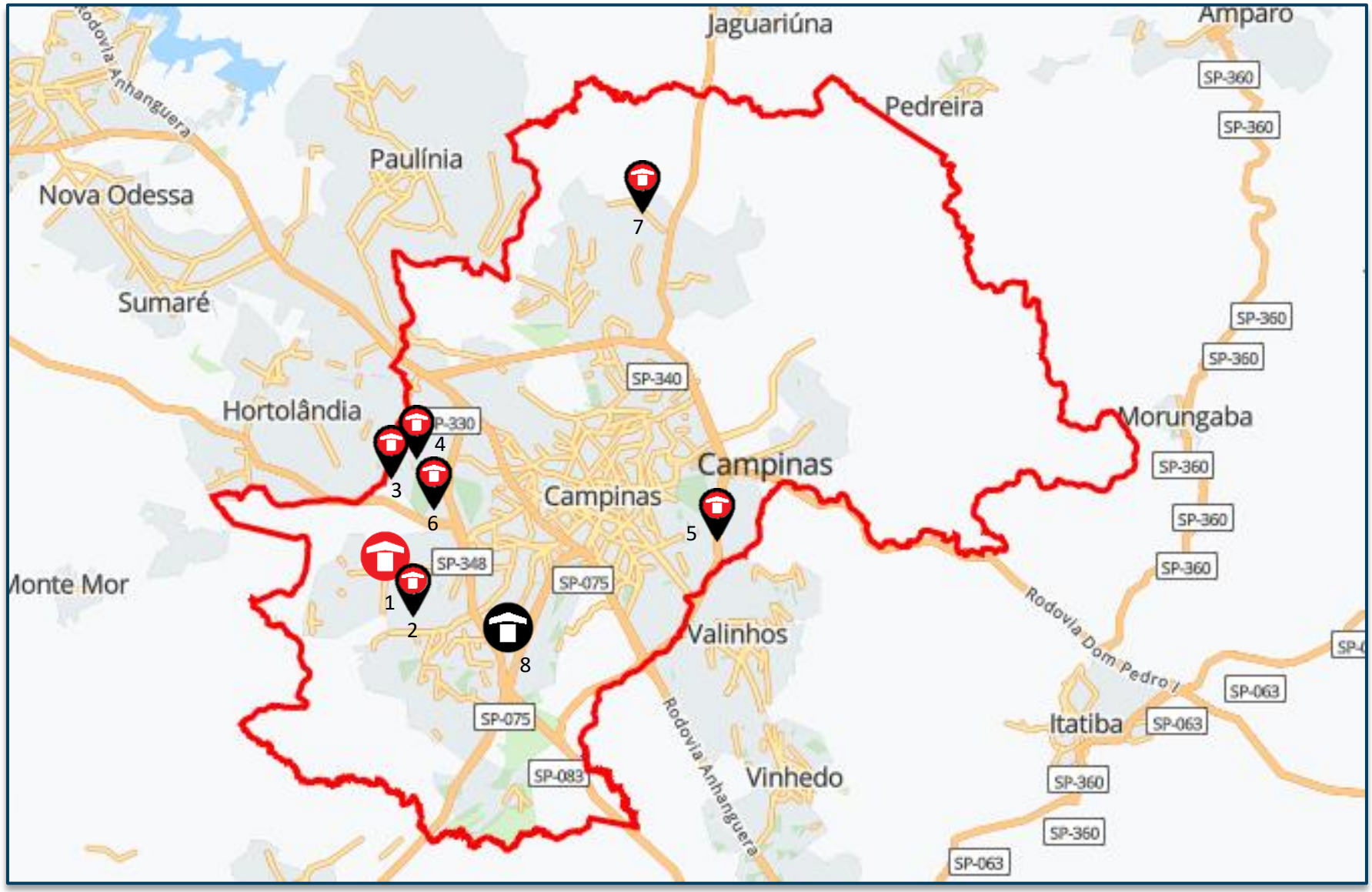

Lançados *LandBank* *Comitê*

Localização

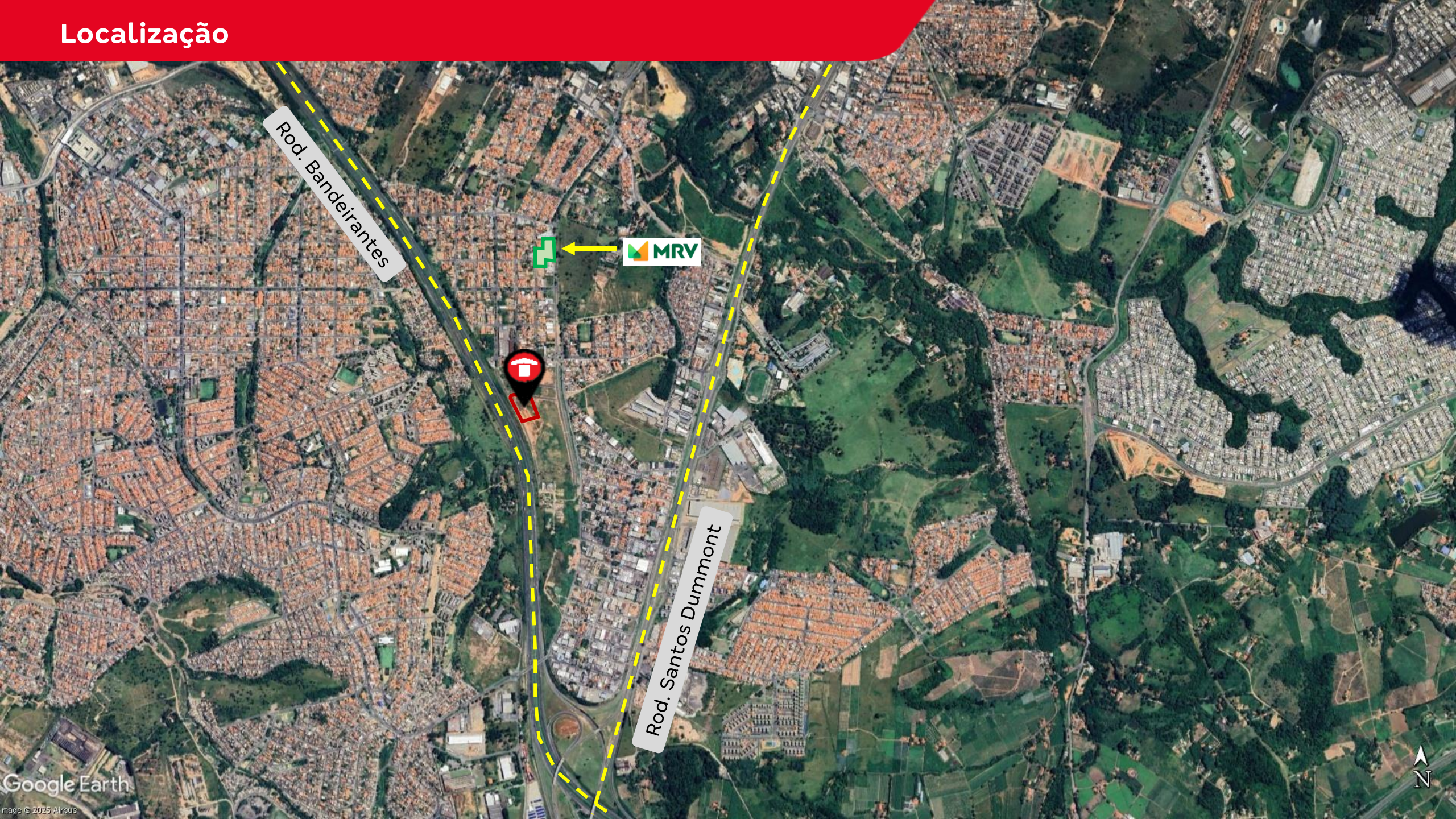

PRODUTO

Empreendimento Furacão - CPS Investimento

Informações Gerais – Condomínio Único		
Terreno	Área terreno real	10.250,95m²
	Área Matrícula	10.250,95m²
	Menor Poligonal	10.250,95m²
	Melhoramento de calçada	Sim
	Área liquida	10.250,95m²
	Zoneamento	ZC – 2
	CA máximo	3,00
	CA básico	1,00
	CA projetado	2,03
	Gabarito máximo	T+15
Geral	Total uh	537
	Total de vagas (autos | motos)	297 (55%)
Tipologia	Tipologia	CPS-0100-LN-PC10-CE2A-10PP CPS-0100-LN-PC10-CE2A-12PP
	Gabarito	T+15
	Lâmina	01 10PP | 02 12PP
	Área privativa	38,01 | 38,30 m²
Condomínio	Unidade PCD	17
	Unidade lazer	07
	Torre	03
	Fase	01
Lazer	Lazer coberto	Churrasqueira c/ Banheiro, Salão de Festas Gourmet, Brinquedoteca, Espaço Office, Fitness, Espaço Saúde e Espaço teen.
	Lazer descoberto	Playground kids, playground baby e praça de convivência

IMPLANTAÇÃO

PRODUTO

Empreendimento Furacão - CPS Investimento

	Descrição	Criticidade	Parecer
Usabilidade	Limite supercondomínio	🟢	
	Acesso	🟢	
	Percurso do pedestre até torre	🟡	Desnível:8,00 | Maior percurso: 177m
Diferencial produto	Prime	Não	
	Atributos Infra	Não	
	Atributos Torre	Não	
	Edifício Garagem	Não	

Pareceres

Análise da Mancha e Implantação

Prospecção

Operações

Inteligência de Mercado

Financeiro

Condições do Negócio

VALOR DO NEGÓCIO

- Valor de face: R$ 9.000.000,00 (Compra parcelada).

CONDIÇÃO

- R$9.000.0000,00- Em 24 parcelas iniciando após a conclusão do prazo firmado na opção.
- Valor corrido pelo IPCA – (Correção se inicia no pagamento da primeira parcela com data base na data da escritura)
- 11 uhs em permuta física, equivalente a 2% do total de unidades destinados a COHAB Campinas, como contrapartida pela parceria no processo de aprovação do empreendimento.

INTERMEDIAÇÃO IMOBILIÁRIA

- 6% do valor total da aquisição do terreno, no valor total de R$540.000,00 pagos a XR INTERMEDIAÇÕES DE IMÓVEIS E NEGÓCIOS EIRELI, da seguinte forma: 6 parcelas, sendo a primeira parcela paga em até 30 dias contados da assinatura da escritura definitiva e as demais sucessivamente.

GARANTIAS

- Para os vendedores – Seguro Garantia

CONDIÇÕES RESOLUTIVAS

- Contrato de opção assinado 24/06/2024 com prazo de 14 meses (Prorrogável por mais 60 dias – out25) para aprovação (não vinculante no ctr) e escritura e início de pagamento;
- Em função da necessidade de regularização da área (mudança de aprovação de comercial para residencial), foi alinhado com o vendedor uma repactuação do prazo de acordo como nosso cronograma de lançamento – **Obs: a assinatura deste aditamento de prazo é condição para baixa do landbank no 2T25.**

- Pareceres
- Análise da Mancha e Implantação
- Prospecção
- Operações
- Inteligência de Mercado
- Financeiro

Comitê

	FURACÃO 2000 CEN01 | REV01	FURACÃO 2000 CEN01 | REV00	CHÁCARAS MORUMBI CEN02 - UNIFICADO| R02 CONSOLIDADO	PORTAL MONTE ALTO CEN01 | REV02 CONSOLIDADO
Torres	3	3	3	5
Unidades Construídas	544	544	588	210 | 270 | 260
Unidades Vendidas	537	537	585	204 | 261 | 251
Total Unidades Vendidas	537	537	585	716
Condomínios (qta.)	1	1	1	3
Cidade	Campinas - SP	Campinas - SP	Campinas - SP	Campinas - SP
Produto / Selo	F2E MODULAR	F2E MODULAR	F2E MODULAR	F2E MODULAR
Tipologia	1 Torre | T+15 | 10PP | C2A	1 Torre | T+15 | 10PP | C2A	2 Torres | T+14 | 14PP | C2A	4 Torres | T+12 | 10PP | C1A
Tipologia	2 Torres | T+15 | 12PP | C2A	2 Torres | T+15 | 12PP | C2A	1 Torre | T+13 | 12PP | C2A	1 Torre | T+14 | 14PP | C2A
Atributos de Projeto			-	-
Projeto Infra	AP	AP	AP	AP
Projeto Torre	AP	AP	EP | LO	EP/LO
Mês Base	junho-25	setembro-24	junho-25	março-25
Incc	1.191,327	1.134,775	1.191,327	1.173,775
LVS	abril-25	jul/24	abril-25	fevereiro-25
Indiretos	abril-25	jul/24	abril-25	fevereiro-25
Base de Preço	LPU 91	LPU 82	LPU 91	LPU 86
Takt	2x2	2x2	2x2	2X2
Prazo (mês)	19	19	19	15 | 16 | 15
CUSTO TOTAL I	R$ / UND R$ 101.900	R$ / UND R$ 99.708	R$ / UND R$ 99.221	R$ / UND R$ 109.633
Indireto	R$ 18.873	R$ 19.226	R$ 18.521	R$ 25.310
Torre	R$ 59.637	R$ 56.826	R$ 58.066	R$ 57.559
Infra	R$ 14.403	R$ 14.759	R$ 14.804	R$ 18.199
Fundação	R$ 7.547	R$ 7.195	R$ 6.404	R$ 6.809
EEE			R$ 652	R$ 437
ETE				
Contenção	R$ 662	R$ 657		R$ 431
Terraplenagem	R$ 778	R$ 1.045	R$ 774	R$ 888
CUSTO TOTAL II	R$ 2.888	R$ 2.212	R$ 7.022	R$ 4.693
Urbanização	R$ 266	R$ 209	R$ 3.055	R$ 3.323
Drenagem	R$ 105		R$ 1.492	
Extensão de Rede Elétrica	R$ 233	R$ 223	R$ 205	R$ 140
Extensão de Rede Hidráulica	R$ 2.284	R$ 1.779	R$ 2.270	R$ 1.230
CUSTO TOTAL III				
Incorridos				
CUSTO TOTAL IV				
Aprendizado				
CUSTO TOTAL V		R$ 5.079		R$ 1.710
Atualização por INCC		R$ 5.079		R$ 1.710
CUSTO TOTAL I+II	R$ 104.788	R$ 101.920	R$ 106.243	R$ 114.326
CUSTO TOTAL I AO IV	R$ 104.788	R$ 106.999	R$ 106.243	R$ 116.036

Custo de Construção

	FURACÃO 2000 CEN01 | REV01	CHÁCARAS MORUMBI CEN02 - UNIFICADO| R02 CONSOLIDADO
Torres	3	3
Unidades Construídas	544	588
Unidades Vendidas	537	585
Total Unidades Vendidas	537	585
Condomínios (qta.)	1	1
Cidade	Campinas - SP	Campinas - SP
Produto / Selo	F2E MODULAR	F2E MODULAR
Tipologia	1 Torre | T+15 | 10PP | C2A	2 Torres | T+14 | 14PP | C2A
Tipologia	2 Torres | T+15 | 12PP | C2A	1 Torre | T+13 | 12PP | C2A
Atributos de Projeto	-	-
Projeto Infra	AP	AP
Projeto Torre	AP	EP | LO
Mês Base	junho-25	junho-25
Incc	1.191,327	1191,33
LVS	abril-25	abril-25
Indiretos	abril-25	abril-25
Base de Preço	LPU 91	LPU 91
Takt	2x2	2x2
Prazo (mês)	19	19

CUSTO TOTAL I	R$ / UND R$ 101.900	R$ / UND R$ 99.221	DIF R$ 2.679
Indireto	R$ 18.873	R$ 18.521	R$ 352
Torre	R$ 59.637	R$ 58.066	R$ 1.571
Infra	R$ 14.403	R$ 14.804	-R$ 401
Fundação	R$ 7.547	R$ 6.404	R$ 1.144
EEE	R$ 0	R$ 652	-R$ 652
ETE	R$ 0	R$ 0	R$ 0
Contenção	R$ 662	R$ 0	R$ 662
Terrapplenagem	R$ 778	R$ 774	R$ 3
CUSTO TOTAL II	R$ 2.888	R$ 7.022	-R$ 4.135
Urbanização	R$ 266	R$ 3.055	-R$ 2.789
Drenagem	R$ 105	R$ 1.492	-R$ 1.388
Extensão de Rede Eletrica	R$ 233	R$ 205	R$ 28
Extensão de Rede Hidráulica	R$ 2.284	R$ 2.270	R$ 14
CUSTO TOTAL III	R$ 0	R$ 0	R$ 0
Incorridos	R$ 0	R$ 0	R$ 0
CUSTO TOTAL IV	R$ 0	R$ 0	R$ 0
Aprendizado	R$ 0	R$ 0	R$ 0
CUSTO TOTAL V	R$ 0	R$ 0	R$ 0
Atualização por INCC	R$ 0	R$ 0	R$ 0
CUSTO TOTAL	R$ 104.788	R$ 106.243	-R$ 1.456

INDIRETOS
+218 | G14 – Administração (Diluição)
+179 | G15 – Operação do Canteiro (Diluição)
-110 | G18 – Ensaios (Ensaio Estacas – Menor quantidade de Estacas)

TORRE
+133 | Vertical (Diluição)
-455 | Instalações Torre (Diferença de tipologia)
+80 | Aço (Diluição)
Furacão 2000 REV01: 39,12 kg/m³ | 6,46 R$/kg
Chácaras: 39,65 kg/m³ | 6,36 R$/kg
+279 | Concreto (Consumo)
Furacão 2000 REV01: 13,59 m³/uh – Preço médio R$ 632,05
Chácaras: 13,13 m³/uh – Preço médio R$ 632,85
-165 | Esquadria de Alumínio (Caixilho Acústico Classe III)
Furacão 2000 REV01: 80 UH
Chácaras: 264 UH
+157 | Esquadria de Ferro (Projeto)
+1.377 | Elevador (Projeto)
Furacão 2000 REV01:
10PP T+15 – 3 elev. /torre | 1,5m/s
12PP T+15 – 6 elev. /torre | 1,5m/s – 6.703 R$/U.H
Chácaras:
12PP T+13 – 2 elev. /torre | 1,75m/s
14PP T+14 – 6 elev. /torre | 1,5m/s – 5.326 R$/U.H

INFRA
-252 | Outros Revest. Pisos (Projeto)
+441 | Reservatório Metálico (Projeto)
Furacão 2000 REV001: 3 Reservatórios: 2 c/ altura de 12,50m e 1 c/ altura 7,00m - Ø 3.80m
Chácaras: 1 Reservatório c/ altura de 26,97m - Ø 3.80m
-796 | Outras Instalações (Projeto)
Chácaras: 2 Salões de Festa e Quadra Gramada.
+218 | Enterrados
Furacão 2000 REV001: Tanque de Retardo – V = 112,58m³
Chácaras: Tanque de Retardo – V = 91,89m³

FUNDAÇÃO
+1.144 | Projeto
Furacão 2000 REV001: Estaca Hélice Ø 40, 50 e 60 cm - L =18 a 20m.
Chácaras: Estaca Hélice Ø 35, 40, 50 e 60 cm - L = 9 a 11m.

CONTENÇÃO
+662 | Projeto
Furacão 2000 REV001: Área de contenção = 89,06m²

Custo de Construção

	FURACÃO 2000 CEN01 | REV01	FURACÃO 2000 CEN01 | REV00	
Torres	3	3	
Unidades Construídas	544	544	
Unidades Vendidas	537	537	
Total Unidades Vendidas	537	537	
Condomínios (qta.)	1	1	
Cidade	Campinas - SP	Campinas - SP	
Produto / Selo	F2E MODULAR	F2E MODULAR	
Tipologia	1 Torre | T+15 | 10PP | C2A	1 Torre | T+15 | 10PP | C2A	
Tipologia	2 Torres | T+15 | 12PP | C2A	2 Torres | T+15 | 12PP | C2A	
Atributos de Projeto	0	0	
Projeto Infra	AP	AP	
Projeto Torre	AP	AP	
Mês Base	junho-25	setembro-24	
Incc	1.191,327	1134,775	
LVS	abril-25	julho-24	
Indiretos	abril-25	julho-24	
Base de Preço	LPU 91	LPU 82	
Takt	2x2	2x2	
Prazo (mês)	19	19	
CUSTO TOTAL I	R$ / UND R$ 101.900	R$ / UND R$ 99.708	DIF R$ 2.192
Indireto	R$ 18.873	R$ 19.226	-R$ 353
Torre	R$ 59.637	R$ 56.826	R$ 2.810
Infra	R$ 14.403	R$ 14.759	-R$ 356
Fundação	R$ 7.547	R$ 7.195	R$ 352
EEE	R$ 0	R$ 0	R$ 0
ETE	R$ 0	R$ 0	R$ 0
Contenção	R$ 662	R$ 657	R$ 5
Terraplenagem	R$ 778	R$ 1.045	-R$ 267
CUSTO TOTAL II	R$ 2.888	R$ 2.212	R$ 676
Urbanização	R$ 266	R$ 209	R$ 57
Drenagem	R$ 105	R$ 0	R$ 105
Extensão de Rede Eletrica	R$ 233	R$ 223	R$ 9
Extensão de Rede Hidráulica	R$ 2.284	R$ 1.779	R$ 505
CUSTO TOTAL III	R$ 0	R$ 0	R$ 0
Incorridos	R$ 0	R$ 0	R$ 0
CUSTO TOTAL IV	R$ 0	R$ 0	R$ 0
Aprendizado	R$ 0	R$ 0	R$ 0
CUSTO TOTAL V	R$ 0	R$ 5.079	-R$ 5.079
Atualização por INCC	R$ 0	R$ 5.079	-R$ 5.079
CUSTO TOTAL	R$ 104.788	R$ 106.999	-R$ 2.211

INDIRETOS

-367 | G11 – Serviços Técnicos (Retroalimentação LVS Abr/25)
+461 | G13 – Pessoal Permanente (Equipe GAPE)
-1.029 | G14 – Administração (Vigilância Ronda)
+867 | G16 – Equipamentos (Absorção de SLQA conforme nova premissa LOG)
-561 | G17 – Operação de Canteiro (Diminuição de quantitativo de Balancim – revisão QC R08)
+248 | G19 – Transporte e Limpeza (Reajuste valores de frete)

TORRE

+2.673 | Vertical (Retroalimentação LVS Abr/25 x Jul/24)
+316 | Instalações Torre (Retroalimentação LVS Abr/25 x Jul/24 – Diferença de referência de instalações)
+128 | Consumo Fôrmas (Atualização coeficientes e quantidades)
-426 | Concreto (Preço)
Furacão 2000 REV01: 13.59 m³/uh – Preço médio R$ 632,05
Furacão 2000 REV00: 13,59 m³/uh – Preço médio R$ 674,09
-387 | Gesso Acartonado (Composição de Shafts por M²)
+337 | Esquadria de Madeira (Absorção de nova composição)
+150 | Esquadrias de Alumínio (Preço)
-178 | Elevador (Cotação Otis + 20% de Desconto)

INFRA

-101 | Esquadria de Ferro (Preço)
-97 | Reservatório Metálico (Absorção de nova composição)
+99 | Enterrados (Atualização de Referência)
-322 | Instalações Infra (Retroalimentação LVS Abr/25 x Jul/24)

FUNDAÇÃO

+352 | Atualização de Preço
Furacão 2000 REV01: Lajão R$ 3.470,00/m³
Estaca Hélice Ø 40, 50 e 60 cm L=18 a 20m - R$ 274/m.
Furacão 2000 REV00: Lajão R$ 3.162,00/m³
Estaca Hélice Ø 40, 50 e 60 cm L=18 a 20m - R$ 272/m.

TERRAPLENAGEM

-267 | Atualização de Preço
(Reajuste conforme alinhado com suprimentos)

EXTENSÃO DE ÁGUA

+505 | Preço (Atualização de Referência – Obra Gran Vista 02/25)

Operações

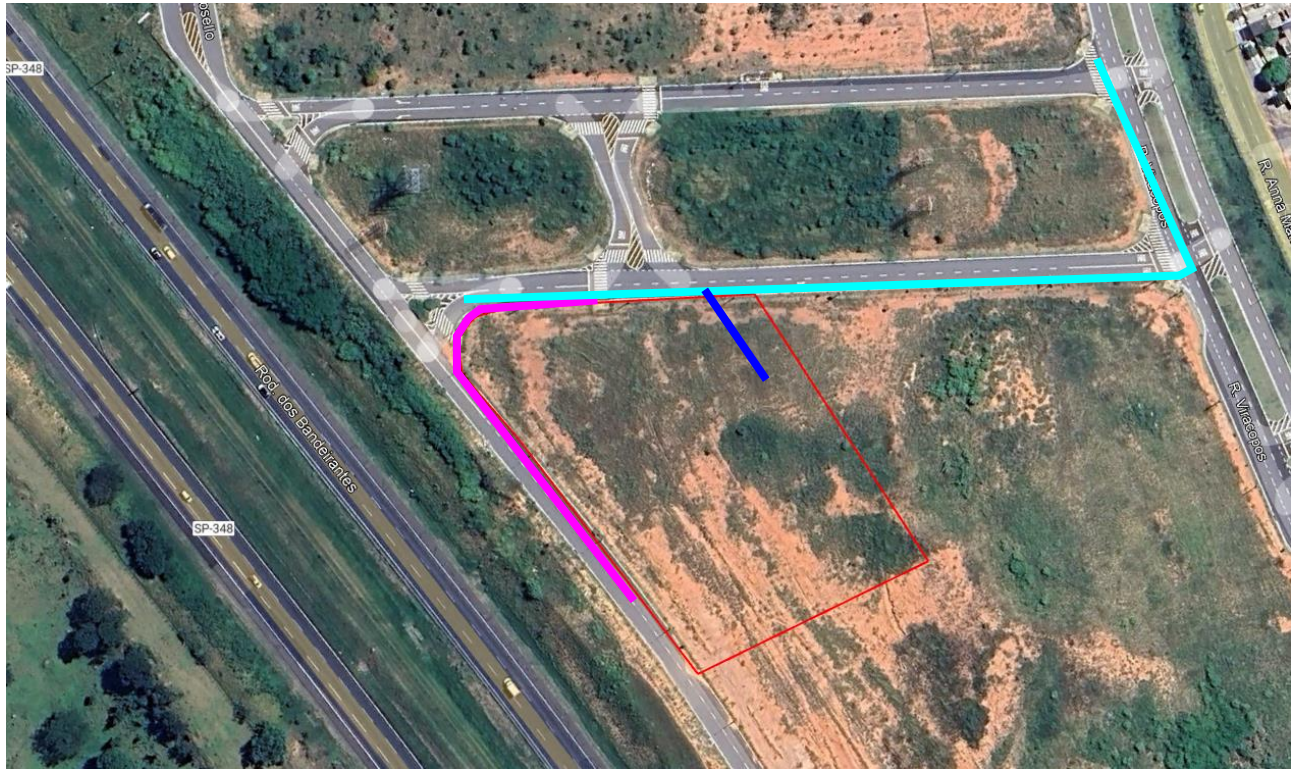

SISTEMA DE ABASTECIMENTO DE ÁGUA
Execução de 290m de extensão de rede água de PEAD 160mm.

SISTEMA DE ESGOTAMENTO SANITÁRIO
Ligação na porta, mediante a participação da na ETE Capivari II.

SISTEMA DE DRENAGEM
Considerado 8m de rede, conforme alinhado com regional.

SISTEMA DE ABASTECIMENTO DE GÁS
Abastecimento por GLP.

SISTEMA DE ABASTECIMENTO ELÉTRICO
Aguardando diretrizes.

TERRENO

URBANIZAÇÃO
Considerado apenas calçada perimetral.

Operações

Matriz Risco Concessionária	
Água	Nível 3
Esgoto	Nível 3
Drenagem	Nível 5
Elétrica	Nível 5
Gás	NA
Urbanização	NA

LEGENDA		
Nível	Tipo	Status
1	Com Diretriz	Conclusiva
2		Conclusiva com projeto aprovado
3		Conclusiva sem projeto aprovado
4		Não Conclusiva
5	Sem Diretriz	-
NA	-	Não aplicável

Água:
- Diretriz para 665UH, emitida em 27 de agosto de 2024, com validade de 6 meses. Execução de 290m de extensão em PEAD 160mm.

Esgoto:
- Diretriz para 665UH, emitida em 27 de agosto de 2024, com validade de 6 meses.

Drenagem:
- Sem viabilidade. Existe rede de drenagem, considerado apenas um trecho para ligação à rede existente de aproximadamente 8m, conforme alinhado com a regional.

Elétrica:
- Viabilidade não disponibilizada, no pedido de ligação definitiva a concessionária poderá cobrar reformas.

Gás:
- Empreendimento com GLP.

Urbanização:
- Considerado execução da calçada perimetral.

Fundação:
- Realizada campanha de sondagem contemplando 07 furos.
- Considerada Estaca Hélice, com diâmetros de 40, 50 e 60 e profundidade de 18 a 20m.

Logística – CEN 1

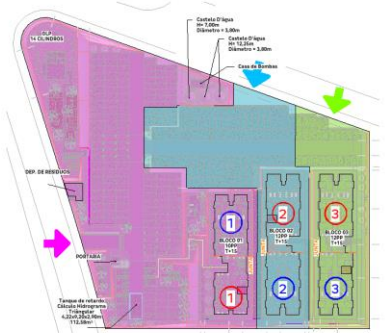

MODULAÇÃO E TOMBAMENTO

TENDAS_PERÍODOS							
DESCRIÇÃO	QUANTIDADE	LARGURA	COMPRIMENTO	PRÉ FORMA	ESTRUTURA	ACABAMENTO	FASE
_TENDA_DESMOLDANTE (LOG)	1	2,00	4,00	-	TODO PERÍODO	-	
_TENDA_TENDA ACABAMENTO (LOG)	1	8,00	8,00	-	TODO PERÍODO	TODO PERÍODO	
_TENDA_TENDA ARMADOR (LOG)	1	4,00	6,00	TODO PERÍODO	TODO PERÍODO	-	
_TENDA_TENDA CENTRAL DE KITS (LOG)	1	8,00	8,00	-	TODO PERÍODO	TODO PERÍODO	
_TENDA_TENDA CENTRAL DE PORTAS (LOG)	1	8,00	8,00	-	TODO PERÍODO	TODO PERÍODO	
_TENDA_TENDA LAZER (LOG)	1	4,82	7,28	-	TODO PERÍODO	TODO PERÍODO	
_TENDA_TENDA MOLDADOR (LOG)	1	4,00	5,00	TODO PERÍODO	TODO PERÍODO	-	

VIVENCIA - CONTAINERS							
DESCRIÇÃO	QUANTIDADE	MOBILIZAÇÃO	DESMOBILIZAÇÃO	PRÉ FORMA	ESTRUTURA	ACABAMENTO	FASE
_TENDA_CONTAINER ALMOXARIFADO (LOG)	1 MODULO DE CONTAINER	1 MOB	1 DESMOB	-	TODO PERÍODO	TODO PERÍODO	
_TENDA_CONTAINER PORTARIA (LOG)	1 MODULO COM SANITARIO	1 MOB	1 DESMOB	TODO PERÍODO	TODO PERÍODO	TODO PERÍODO	
_TENDA_CONTAINER PROVISÓRIO (LOG)	8 MODULOS DE CONTAINER	1 MOB	1 DESMOB	TODO PERÍODO	-	-	
_TENDA_CONTAINER VESTIARIO ACABAMENTO (LOG)	2 MODULOS DE CONTAINER	1 MOB	1 DESMOB	-	-	TODO PERÍODO	
_TENDA_CONTAINER VESTIARIO ESTRUTURA (LOG)	2 MODULOS DE CONTAINER	1 MOB	1 DESMOB	-	-	TODO PERÍODO	
_TENDA_CONTAINER VIVÊNCIA PADRÃO (LOG)	7 MODULOS DE CONTAINER EMBAIXO, 7 MODULOS EM CIMA	1 MOB	1 DESMOB	-	TODO PERÍODO	TODO PERÍODO	

EQUIPAMENTOS E MAQUINÁRIOS							
EQUIPAMENTO	QUANTIDADE	MOBILIZAÇÃO	DESMOBILIZAÇÃO	PRÉ FORMA	ESTRUTURA	ACABAMENTO	FASE
_TENDA_BETONEIRA (LOG)	VARIAVEL	-	-	TODO PERÍODO	TODO PERÍODO	-	
_TENDA_BOBCAT (LOG)	1 EQUIP	1 MOB	1 DESMOB	-	TODO PERÍODO	CONSIDERAR POR 15 DIAS	
_TENDA_BOMBA ESTACIONARIA PADRAO (LOG)_R01	1 EQUIP PARA OS BLOCOS 02 E 03	1 MOB	1 DESMOB	-	TODO PERÍODO	-	
_TENDA_BOMBA ESTACIONARIA PADRAO (LOG)_R01	1 EQUIP PARA OS BLOCOS 02 E 03	1 MOB	1 DESMOB	TODO PERÍODO	TODO PERÍODO	-	
_TENDA_CAMINHAO MUNK (LOG)	1 EQUIP	1 MOB	1 DESMOB	-	CONSIDERAR MEIO PERIODO	-	
_TENDA_CREMALHEIRA PCT (LOG)_R01	2 EQUIP	1 MOB POR TORRE	1 DESMOB POR TORRE				
_TENDA_MINIGRUA (LOG)	2 EQUIP	1 MOB POR MINIGRUA POR TORRE (TAKT 2X2)	1 DESMOB POR MINIGRUA POR TORRE (TAKT 2X2)	-	TODO PERÍODO	-	

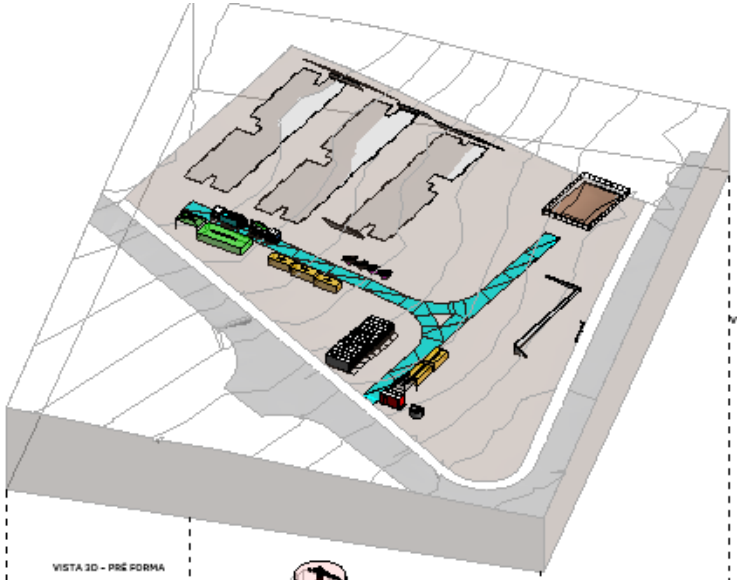

VISTA 3D - PRÉ FORMA

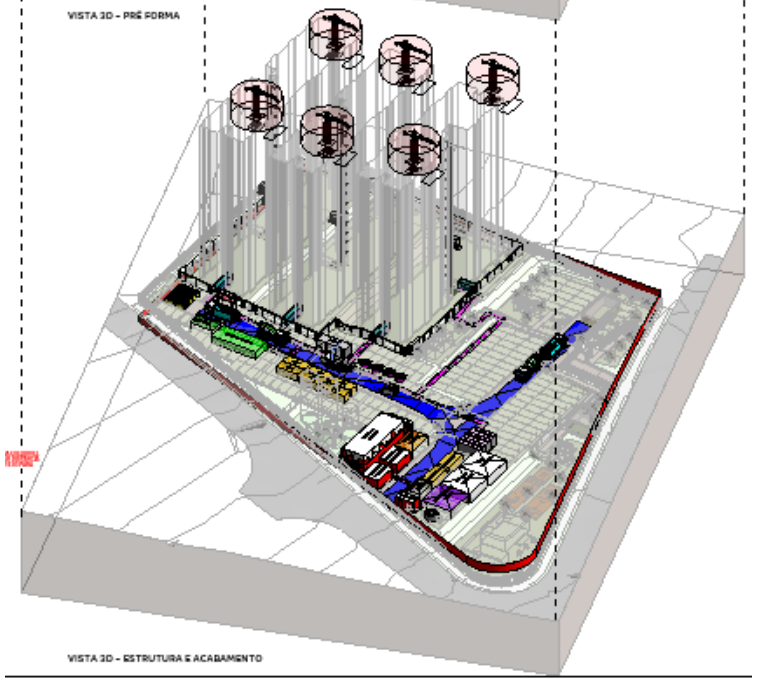

VISTA 3D - ESTRUTURA E ACABAMENTO

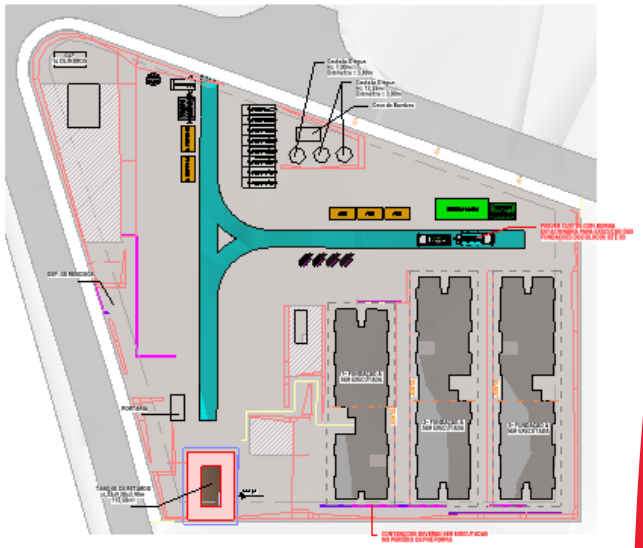

PRE FORMA

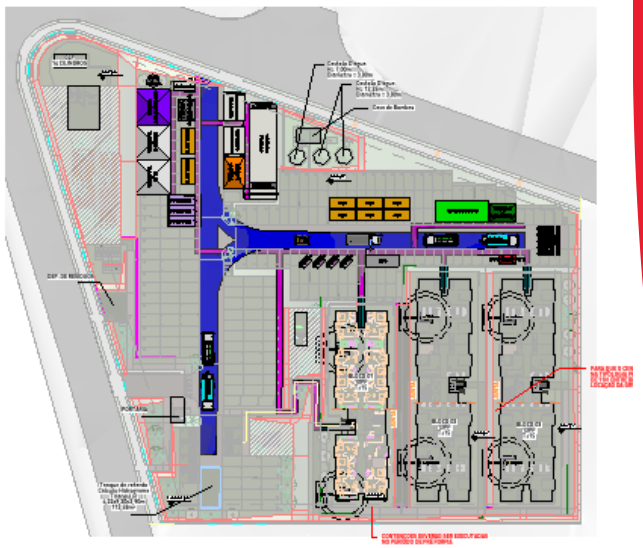

ESTRUTURA E ACABAMENTO

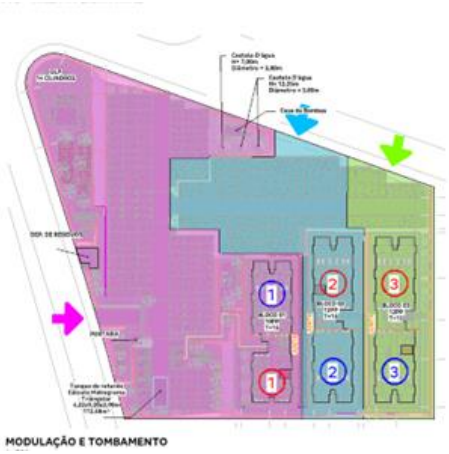

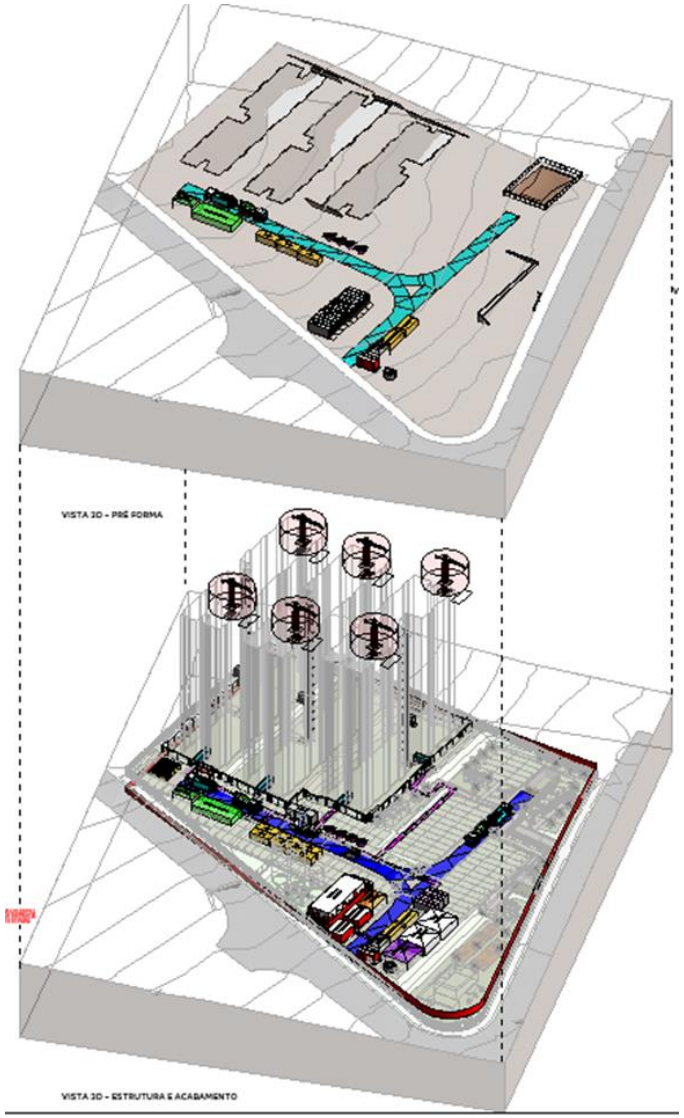

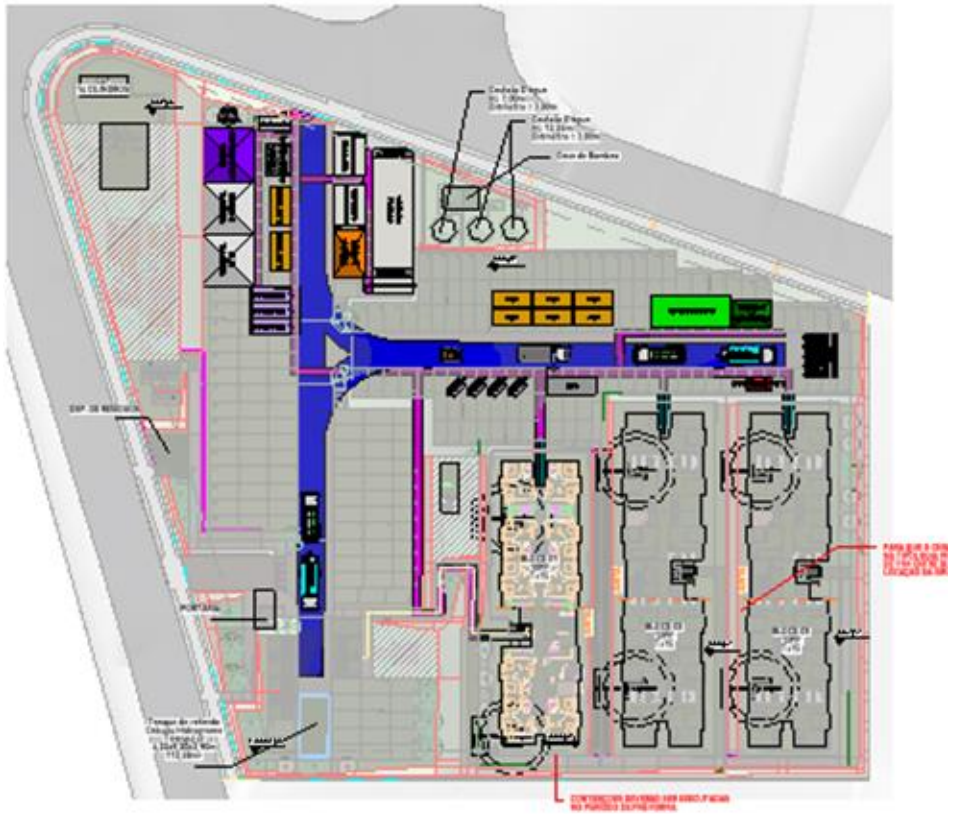

OBS.: 01

➢ **OBS. 01**	CONTENÇÕES DEVERÃO SER EXECUTADAS NO INÍCIO DO PERÍODO DE PRÉ FORMA

Logística

ITENS A SEREM CONSIDERADOS:

➢ **CUSTOS / OBRA**	PREVER CUSTO PARA PERDA DE CONCRETO DURANTE O PERÍODO DE FUNDAÇÃO E ESTRUTURA COM UTILIZAÇÃO DE BOMBA ESTACIONÁRIA PARA A CONCRETAGEM CONFORME INDICADO EM PROJETO, NECESSÁRIO DEVIDO À DISTÂNCIA ENTRE PONTO DE PATOLA E BLOCOS E AO GABARITO. NÃO HÁ ALCANCE DO RAIO DO MUNCK PARA MOBILIZAR E DESMOBILIZAR A CREMALHEIRA DOS BLOCOS 02 E 03. ASSIM, A MOBILIZAÇÃO DEVERÁ SER FEITA COM A BOBCAT. PREVER LARGURA SUFICIENTE PARA PASSAGEM DESTE MAQUINÁRIO E PREVER COM SUPRIMENTOS CONTRATAÇÃO DE CREMALHEIRA COM CABINE DESMONTÁVEL. CASO A CABINE NÃO SEJA DESMONTÁVEL, SERÁ NECESSÁRIO CONTRATAR UM GUINDASTE DE GRANDE PORTE.
➢ **PRAZO DE OBRA**	PREVER PRAZO NO PERÍODO DE PRÉ FORMA PARA EXECUÇÃO DE CONTENÇÕES CRÍTICAS (CONFORME INDICADO EM PROJETO).

Pareceres

Análise da Mancha e Implantação

Prospecção

Operações

Inteligência de Mercado

Financeiro

Demanda e Distribuição da Mancha

Potencial de Demanda			Lançados		Lançados + Landbank	
Mancha	CÓD.	Shr.	ANO	MÊS	ANO	MÊS
Campinas	CPS	53%	2.178	181	2.613	218

Empreendimento	Renda	Lançamento	mar/27	abr/27	mai/27	jun/27	jul/27	ago/27	set/27	out/27	nov/27	dez/27	jan/28	fev/28	mar/28	abr/28	mai/28	jun/28	jul/28	ago/28	set/28	out/28	nov/28	dez/28
Gran Vista	2.994	dez-25	27	27	27	27	2																	
Vale Da Mata	3.441	jun-26	22	22	22	22	22	22	22	22	22	14												
Portal Monte Alto IIi	3.115	out-26	16	16	16	16	16	16	16	16	16	16	16	16	16	15								
Vila Ouro Verde II	2.153	nov-26	14	14	14	14	14	14	14	14	14	14	14	14	14	14	14	3						
Furacão	**3.377**	**mar-27**		**29**	**29**	**29**	**29**	**29**	**29**	**29**	**29**	**29**	**29**	**29**	**29**	**29**	**29**	**29**	**29**	**29**	**29**	**4**		
Solar Das Flores I	3.849	jun-27					28	28	28	28	28	28	28	28	28	28	28	28	28	28	28	28	28	25
Chácaras Morumbi	3.226	dez-27											30	30	30	30	30	30	30	30	30	30	30	30
Portal Monte Alto I	3.073	abr-28															12	12	12	12	12	12	12	12
Vista Da Mata F1	3.441	jun-28																	23	23	23	23	23	23
Vista Monte Alto I - F1	2.710	ago-28																			31	31	31	31
Vista Ouro Verde I	2.153	nov-28																						25
Total de Vendas Lançados			**0**	**0**	**0**	**0**	**0**	**0**	**0**	**0**	**0**	**0**	**0**	**0**	**0**	**0**	**0**	**0**	**0**	**0**	**0**	**0**	**0**	**0**
Total de Vendas Lançados + Landbank			**79**	**108**	**108**	**108**	**111**	**109**	**109**	**109**	**109**	**101**	**117**	**117**	**117**	**116**	**113**	**102**	**122**	**122**	**153**	**128**	**124**	**146**

Parecer de I.M sobre a mancha:

O projeto analisado em comitê está em linha com o potencial teórico de demanda calculado para a mancha. (Total Lanç + Landbank)

Canibalização:

Sem Risco de Canibalização

Furacão | Mapa Concorrência

		Furacão	Colina Do Sol	Recanto Dos Ipês	Canoas
		TENDA	MRV	Zuma	MRV
	Distância Tenda (km)		6,5 Km	3,27Km	1,38Km
Região 1 Km	População	12.383	13.714	16.161	6.246
	Dens. Demográfica	3.967	4.393	5.178	2.001
	Renda (R$)	4.311	4.299	4.129	5.163
	Classe Social	C1 (2.7k a 4.6k)	C1 (2.7k a 4.6k)	C1 (2.7k a 4.6k)	C1 (2.7k a 4.6k)
	PEA Dia	7.528	5.576	5.227	3.454
Quantitativo	Lançamento	jul/27	fev/25	mai/25	jan/24
	Unidades	526	208	60	176
	Estoque	526	91	32	69
	VSO	29	29	28	6
	Stockout	18	3	1	11
Qualitativo	Condomínios	1	1	1	1
	Torres	3	2	8	1
	Gabarito	T+15	T+12	T+4	T+21
	Plantas (m²)	38,16m²	37m² e 37m²	43m²	64,4m² e 40,13m²
	Tipologia	2 Dorms	2 Dorms	2 Dorms	Não
	Opções	Não	Garden	Não	Garden
	Varanda	Não	Não	Não	Não
	Suite	Não	Não	Não	Não
	Dif. Entrega	Não	-	-	-
	Vagas	49% Vagas	100% Com vaga	100% Com vaga	0,74
	Lazer	Churrasqueira, Salão de Festas com Churrasqueira, Salão de Festas sem Churrasqueira, Playground Kids, Playground Baby, Bicicletário, Espaço Office, Salão de Festas Gourmet, Brinquedoteca, Fitness, Espaço Saúde e Espaço Teen.	Tem Garden, Cinema, Piscina, Praça, Quadra de Tênis,	Bosque, Cinema, Fireplace, Pet Place, Piscina, Piscina Aquecida, Praça, Salão de Jogos,	Tem Garden, Bosque, Cinema, Piscina, Piscina Aquecida, Piso Elevado, Praça,

Diagnóstico Concorrência

- Conforme demonstrado na tabela de preços, a concorrência da região pratica preços superiores ao estimado para o Furacão;
- O projeto Colina do Sol é o projeto que mais se assemelha em preços com o Furacão, e acreditamos que é possível fazer o VSO de 29 vendas visto que o concorrente já performa nesse patamar de VSO desde o seu lançamento.

Tipologias	Empreendimento	Furacão			Colina do Sol		Recanto Dos Ipês	Canoas		
	Tipologia	Sem vaga	Vaga moto	Vaga carro	Vaga Moto	Vaga carro	Com vaga	Sem vaga	Vaga moto	Vaga carro
	Preço Nominal	227.227	234.479	240.690	240.990	253.990	270.000	263.990	290.990	329.990
	CEF	178.625	185.226	188.594	192.792	203.192	216.000	211.192	232.792	263.992
	Renda	3.094	3.432	3.661	3.560	3.959	5.380	4.189	4.779	6.159
	Dif Renda				128	527	2.286	1.095	1.347	2.498
	Farol de Factibilidade				🟡	🟢	🟢	🟢	🟢	🟢

Farol Renda
🟢 Acima de 300
🟡 Entre 0 e 300
🔴 Abaixo de 0

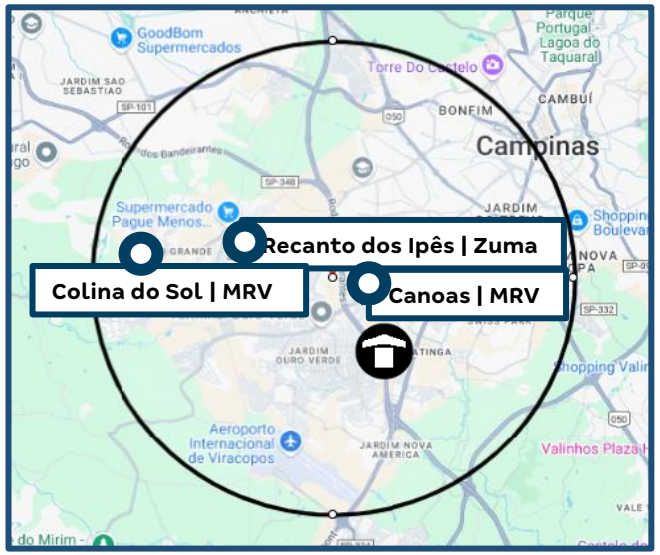

Simulação de Preço

Informações Viabilidade

Projeto:	Furacão					
Tipo:	**Sem vaga**		**Vaga Moto**		**Vaga Carro**	
Método	**Vision**		**Vision**		**Vision**	
Avaliação	236.121		242.328		253.746	
Renda Inicial (VF)	3.094		3.432		3.661	
Renda Final*	-		-		-	
% RET1	50%		25%		25%	
Tipo:	**VF**	**R$**	**VF**	**R$**	**VF**	**R$**
Ato	0,56	1.733	0,67	2.306	0,65	2.385
FGTS	0,65	2.022	0,69	2.390	0,69	2.525
Financiamento	97,17%	167.031	96,19%	178.515	95,25%	182.475
Subsídio	133,56%	9.573	129,04%	4.321	151,15%	3.594
Prazo de Pró-soluto	24	24	24	24	24	24
Pró-Soluto	88,47%	23.868	79,59%	23.820	79,00%	25.219
Preço Raso (RS)	204.226	204.226	211.352	211.352	216.199	216.199
TCD	73,75%	23.001	66,85%	23.127	66,37%	24.491
VSO	14	14	1	1	14	14
Preço de Venda	**225.972**	**225.972**	**233.183**	**233.183**	**239.360**	**239.360**
Elasticidade	0,556%	0,556%	0,556%	0,556%	0,556%	0,556%
Preço de Venda Final	**227.227**	**227.227**	**234.479**	**234.479**	**240.690**	**240.690**
Preço Raso (R$)	**204.226**		**211.352**		**216.199**	
% de Raso	**89,88%**		**90,14%**		**89,82%**	
BP25 - Não Inflacionado	-		-		-	
BP25 - Inflacionado	-		-		-	

Análise de Preço

Informações Viabilidade

Projeto:	Furacão
Tipo:	**Faixa 2**
Método	**Vision**
Avaliação	244.870
Renda Inicial (VF)	3.377
Renda Final*	-

Tipo:	VF	R$
Ato	0,60	2.060
FGTS	0,67	2.274
Financiamento	96,21%	174.767
Subsídio	142,17%	6.569
Prazo de Pró-soluto	24	24
Pró-Soluto	83,70%	24.533
Preço Raso (RS)	210.202	210.202
TCD	70,04%	23.736
VSO	29	29
Preço de Venda	**232.639**	**232.639**
Elasticidade	0,556%	0,556%
Preço de Venda Final	**233.939**	**233.939**
Preço Raso (R$)	**210.202**	
% de Raso	**89,85%**	
Raso Todas as Fases	**210.202**	
Nominal Todas as Fases	**233.939**	

1

Análise de Riscos	Farol IM

IM avalia o Preço Vision como **factível,** porém, com ressalvas para o **VSO**.

1) I.M está de acordo com o preço Vision, tendo em vista que, o projeto está em uma região com bons indicadores sociodemográficos e se encontra próximo de pontos de interesses como supermercados, hospital e da Rodovia dos Bandeirantes.

O desafio desse projeto está no VSO, visto que o Portal das Quaresmeiras, que é o único projeto da regional, não atinge esse patamar de VSO mesmo com a utilização do cheque moradia. Entretanto, conforme consta no slide "Panorama de Concorrência", vimos que a MRV tem atingido um VSO semelhante ao estimado para o Furacão, e por esse motivo, acreditamos que, com a melhor estruturação da regional, a performance de vendas (VSO) deverá evoluir.

	Preço Real					Preço Normalizado (24m)	
	Avaliação	Preço Raso	Renda Média	VSO	PSOL	Δ PSOL	Preço Raso
Portal Quaresmeira	**235.815**	**207.952**	**3.440**	**18**	**23**	**519**	**208.471**
Furacão	**244.870**	**210.202**	**3.377**	**29**	**24**	**-**	**210.202**

Ciclo Financeiro – Análise Mancha

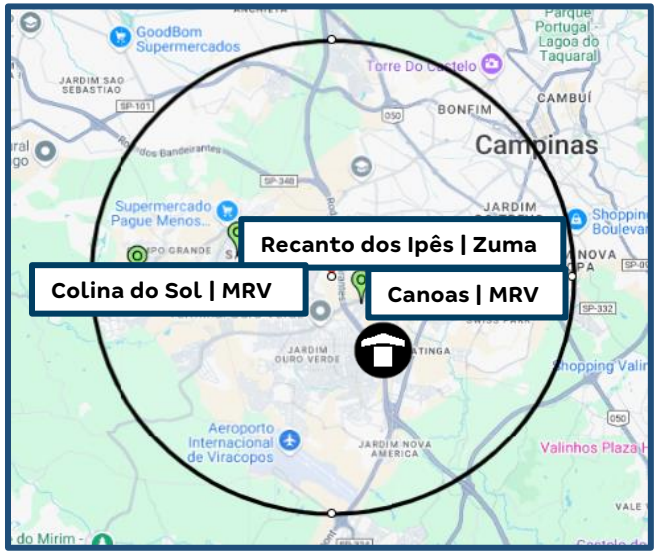

Parecer Ciclo

O Ciclo considerou o Preço e o VSO como viáveis. O projeto está localizado em uma região onde a MRV atua com projeto Colina do Sol com valor semelhante ao Furacão e VSO médio de 30 unidades. O nosso principal desafio está no VSO, já que atualmente não atingimos volumes superiores a 30 unidades. No entanto, os concorrentes têm conseguido esses resultados, o que nos leva a crer que, com uma estrutura mais robusta e bem planejada, será possível absorver a demanda dos próximos lançamentos na região de Campinas.

- Pareceres
- Análise da Mancha e Implantação
- Prospecção
- Operações
- Inteligência de Mercado
- Financeiro

Informações Gerais – Consolidado

Furação 2000 – CPS – Região Metropolitana > 100mil CPS

Datas e Prazos

	Compra	Lançamento	Início Obra	Término Obra	LÇTO até IO	IO até TO	Chaves	LÇTO até Chaves
Consolidado	jun-24							
Faixa 2 - Vaga Auto		mar-27	set-27	abr-29	6 meses	19 meses	mar-30	36 meses
Faixa 2 - Vaga Moto		mar-27	set-27	abr-29	6 meses	19 meses	mar-30	36 meses
Faixa 2 - Sem Vaga		mar-27	set-27	abr-29	6 meses	19 meses	mar-30	36 meses

Terreno e Incorridos

TOTAL (R$ + Perm.):	11,57 MM	Incorrido Terreno:	0,00 MM	Área do Terreno (100%):	10.251 m²
Cash:	9,00 MM			Custo de terreno m²:	1.128,4
Permuta Financeira:	0,00 MM (0,00%)			VaR 25 (R$ mil):	0
Permuta Física:	2,57 MM (2,04%) - Unidades Permuta 11,00			VaR 26 (R$ mil):	0
Ato / %VGV:	0,00 MM / 0,0%			Incorrido de Construção:	0,00 MM

Área Líquida do Terreno:	10.251 m²
Custo de terreno m² Área Líquida:	1.128,4
Fração Terreno/Terreno + Custo Obra (%VGV):	9,2% / 54,0%
CA Máx/Proj.	3,0 / 2,0
Incorridos de Incorporação:	0,00 MM

Vendas

Fases	Nº Pavimentos	Preço Raso Unit.	Qtde	Preço Unit.	Aval. CEF	Cond. Parcela	% Pró-soluto	% TCD
Faixa 2 - Vaga Auto	T+15	216.199	264	240.690	253.746	95,3%	79,0%	66,4%
Faixa 2 - Vaga Moto	T+15	211.352	6	234.479	242.328	96,2%	79,6%	66,9%
Faixa 2 - Sem Vaga	T+15	204.226	267	227.227	236.121	97,2%	88,5%	73,8%

Unidades Totais:	537	Preço Médio:	233.927	Renda Média:	3.377	ITBI+Emol. Unit. Médio:	3.509
Unidades Tenda:	526	Avaliação Média:	244.855	Ato:	2.036 (0,6 Salários)	Custo do Ciclo Unit.:	15.422
VSO:	29 Unidades	VGV Total:	125.618.600	FGTS:	2.256 (0,67 Salários)	Preço Raso Médio:	210.192
RET Médio:	2,9%	VGV Tenda:	123.045.407	% em RET 1%:	37%	Adc. Tx. de Aceleração Médio:	750

Construção

Custo Total Unit. | Corrigido:	104.788 | 104.193	Eventuais:	4,00%	Área priv (m²):	38,86	Gape / Mês Unit.:	11,08

Resultado

LI (R$):	13.075.906	LI:	17,72%	Exposição de Caixa (R$):	17.934.327	Margem Bruta Econômica:	36,72%
TIR:	101,86%	LI Aprovação:	20,00%	Ger. Caixa 12 meses (R$):	0	Margem Bruta REF:	40,15%
Exposição de Caixa:	13,14%	Δ LI:	-2,28%	Ger. Caixa 24 meses (R$):	(3.508.411)	Margem Rasa Econômica:	28,91%
Payback Contingente (21 m):	20 m/ (-1 m)	LI Resiliência:	9,43%	Ger. Caixa Marginal (R$):	32.667.565	Margem Rasa REF:	33,40%
Payback Consolidado:	20 meses					Margem de Contribuição Econômica:	25,59%

DRE

R$ Mil - Valores Nominais - Compra	Furação 2000		Faixa 2 - Vaga Auto		Faixa 2 - Vaga Moto		Faixa 2 - Sem Vaga	
	Nominal	%	Nominal	%	Nominal	%	Nominal	%
Receita	136.530	100,0%	69.057	100,0%	1.558	100,0%	65.916	100,0%
PIS/COFINS	(2.119)	1,6%	(1.207)	1,7%	(28)	1,8%	(883)	1,3%
Custo Total	(85.052)	63,3%	(41.740)	61,5%	(937)	61,3%	(42.374)	65,2%
Custo Terreno	(12.308)	9,2%	(5.986)	8,8%	(106)	6,9%	(6.216)	9,6%
Custo Relacionados a Terreno	(787)	0,6%	(387)	0,6%	(9)	0,6%	(392)	0,6%
Custos de Incorporação	(3.452)	2,6%	(1.689)	2,5%	(57)	3,7%	(1.706)	2,6%
Custo de Construção	(68.504)	51,0%	(33.678)	49,6%	(765)	50,0%	(34.061)	52,4%
Lucro Bruto Econômico	49.359	36,7%	26.109	38,5%	592	38,7%	22.658	34,8%
Custo para Rateio	-	0,0%	-	0,0%	-	0,0%	-	0,0%
Lucro Bruto Contábil	49.359	36,7%	26.109	38,5%	592	38,7%	22.658	34,8%
Despesas de Selling	(11.822)	8,8%	(5.984)	8,8%	(134)	8,7%	(5.705)	8,8%
Contingência	(3.140)	2,3%	(1.588)	2,3%	(36)	2,3%	(1.516)	2,3%
Margem de Contribuição	34.396	25,6%	18.537	27,3%	423	27,6%	15.437	23,7%
IR e CSLL	(1.733)	1,3%	(988)	1,4%	(23)	1,5%	(723)	1,1%
Margem Líquida	32.663	24,3%	17.549	25,9%	400	26,2%	14.714	22,6%
Lucro Bruto REF Unit.	104.897	40,1%	113.079	41,9%	107.594	41,5%	97.427	38,3%
Lucro Raso REF Unit.	78.333	33,4%	85.664	35,4%	82.218	35,2%	71.676	31,3%

R$ Mil - VPL - Compra	Furação 2000		Faixa 2 - Vaga Auto		Faixa 2 - Vaga Moto		Faixa 2 - Sem Vaga	
	VP	%	VP	%	VP	%	VP	%
Receitas	73.808	100,0%	37.324	100,0%	864	100,0%	35.620	100,0%
PIS/COFINS	(1.129)	1,5%	(643)	1,7%	(15)	1,8%	(470)	1,3%
Custos e Despesas Totais	(59.603)	80,8%	(29.454)	78,9%	(675)	78,1%	(29.475)	82,7%
Custo Terreno	(7.428)	10,1%	(3.618)	9,7%	(66)	7,6%	(3.745)	10,5%
Custo Relacionados a Terreno	(566)	0,8%	(278)	0,7%	(6)	0,7%	(281)	0,8%
Custos de Incorporação	(2.032)	2,8%	(992)	2,7%	(37)	4,3%	(1.003)	2,8%
Custo de Construção	(40.175)	54,4%	(19.751)	52,9%	(449)	51,9%	(19.975)	56,1%
Despesas de Selling	(7.572)	10,3%	(3.830)	10,3%	(94)	10,8%	(3.648)	10,2%
Contingência	(907)	1,2%	(459)	1,2%	(10)	1,2%	(438)	1,2%
IR e CSLL	(923)	1,3%	(526)	1,4%	(12)	1,4%	(385)	1,1%
Lucro Imobiliário	13.076	17,7%	7.226	19,4%	174	20,2%	5.675	15,9%

Tenda

sua próxima conquista