Tenda

sua próxima conquista

Comitê Essencial

Regional: RMSP – Diadema

Projeto: Sete de Setembro

Data Comitê: 23.06.2025

One Page – 7 de Setembro

Cidade	Diadema	**Mancha de demanda**	SPRM - ABCD - ABCD
Regional	SPRM	**Cluster MPR**	3 - Verde
Cenário de Aprovação	Aprovação	**Tipo de Aprovação**	Consolidado
Fase Anterior	N/A		
Tipo de Comitê	Essencial	**Versão da VF**	Versão 1.0: Jun

Unidades (% Vagas)	944 (15%)	**CA Máx | Proj**	5,0 | 4,8
Tipologia	F2E Plus - Concreto	**Escritura**	set-26
Fases	2 fases	**Lçto | Duração (m)**	dez/26 | 43

Valor Líquido do Terreno (% VGV)	12.825 (5,6%)	**Un. Perm. Fís (% Ter)**	0 (0,0%)
Cash (Correção)	540 (NA)	**%VGV Perm Fin Líquida (% Ter)**	5,4% (96,3%)
Valor R$/m²	2.101	**VAR (%VGV)**	15 (0,0%)

Custo Construção (%VGV)	98.225 (42,8%)	**Indireto Unit.**	19.350
Prazo da Obra (meses)	21	**Torre Unit.**	61.296
Custo Total Unit. (LPU):	104.051 (LPU91)	**Infra Unit.**	11.453
Início de Obra	jun-27	**Fundação Unit.**	6.114

Preço Nominal Unit.	242.978	**VSO**	27
Preço Raso Unit.	215.722	**Referência**	Vision
Avaliação Unit.	248.814	**Renda (% em RET 1%)**	3.551 (19,3%)

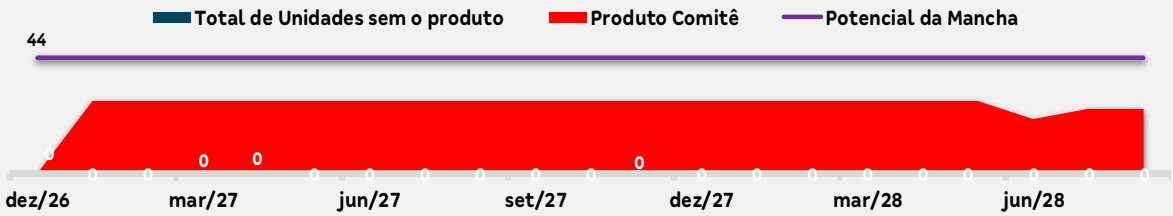

LI (Régua):	**20,1% (20,0%)**	**Margem Bruta Econômica:**	41,0%
LI Resiliência:	13,8% (N/A)	**Margem Rasa Econômica:**	32,6%
Margem Bruta REF:	44,3%	**Margem Contribuição Econômica:**	28,5%
Margem Rasa REF:	**37,3%**	**Exposição (% VGV):**	17.136 (6,7%)
TIR:	93,1%	**VGV Total:**	229.371
Payback Contingente (21 m) :	**20 m/ (-1 m)**	**Ger. Caixa 12 meses (R$):**	(180)
Payback Consolidado:	20	**Ger. Caixa 24 meses (R$):**	(10.075)

Destaques

[1] Terreno localizado na cidade de Diadema (RM), na região do Centro em frente ao Parque do Paço Municipal; região bem abastecida de lazer, comércio e serviços; fácil acesso à Rodovia dos Imigrantes (1Km) e ao corredor de ônibus "Trólebus" (550m) que interliga as cidades de Santo André e São Bernardo do Campo, fazendo ligação direta com a capital paulista via Terminal Jabaquara.

[2] Área Bruta de 8.363m² e Área Líquida (descontando APP) de 6.902m² em zoneamento Eixo de Adensamento Oeste, onde não há exigência de vagas de carro, desde que adotado a proporção 1/1 uh bicicletário (utilizamos muro perimetral como área) e 10% de vagas de moto (viabilizamos a implantação de 15% ao preço raso de 8K); o projeto é composto por 2 condomínios para não ultrapassarmos o limite de 500Uh por empreendimento, eliminando a exigência de doação.

- Projeto atingiu um CA (ponderado) de 4,8x, sendo o CA máx 5x; torres ficaram limitadas ao T+24 nesta fase de desenvolvimento em função de limite de unidades ou limites de recuos (frontal/fundos) pela variação do core;
- Cond. 2 considerando 48% de varandas e cond. 1 tem possibilidade de implantação de varandas com saldo de CA o que seria um *upside* no desenvolvimento do projeto – varanda é área computável; Tipologia modular padrão de SP capital com varanda plugin;
- Projeto enquadrado em HIS-2 com limite de 3 salários de renda (regra Diadema) para 100% do empreendimento; enquadramento como HMP inviabilizaria o negócio em função de regras de doação, tamanho de unidade, outorga e contra partidas maiores;
- Na parte de atributos externos, por enquanto foi viável a implantação também de quadra e salão de festas externo; buscaremos oportunidades/mudanças na etapa de desenvolvimento;
- Lançamentos em duas etapas/condomínios; com VSO médio de 27.

[3] Condição Comercial: R$ 14.500.000,00 - 96,3% em permuta financeira e 3,7% em dinheiro; aproximadamente R$ 364/CA proj. e R$ 1.734/m2.

[4] Aprovação no formato de Comitê Essencial com consideração de 70% das unidades para apuração da meta; o custo de construção e prazo já estão parametrizados, ou seja não foi necessário adotarmos os simuladores neste book; Expectativa de voltarmos com Comitê Ampliado no 2S25; Baixa para landbank no 2T25 depende de finalização da etapa de assinatura do contrato;

Pareceres

Análise da Mancha e Implantação

Prospecção

Operações

Inteligência de Mercado

Financeiro

Anexos

Pareceres

Área	Riscos Associados	Parecer	Criticidade
Jurídico	Observadas as ressalvas mencionadas no parecer jurídico, e desde que implementadas as recomendações formuladas, em especial a manutenção do patrimônio a ser herdado pelas futuras proprietárias como forma de mitigar riscos de insolvência e/ou remediar prejuízos caso seja constatada insolvência até a data da escritura, de acordo com a DD prévia entendemos ser viável darmos andamento aos próximos atos a serem praticados para a efetiva aquisição do terreno. A DD detalhada trará oportunamente análise completa sobre as futuras proprietárias e dos antecessores tabulares, bem como do imóvel.	Ok com ressalvas	
Legalização	Foi realizado estudo aprofundado da legislação aplicável, com consultas ao corpo técnico da prefeitura e análise detalhada do terreno; no entanto, por ser nossa primeira aprovação no município, será necessário aprendizado prático do rito local.	Ok com ressalvas	
DPP	Sem riscos associados	Ok	
Inteligência de mercado	IM avalia o Preço Vision como factível	Ok	
Estudos Econômicos	Sem riscos associados	Ok	
Comercial/Ciclo	Ciclo avaliou preço e VSO como factíveis	Ok	

Pareceres

Análise da Mancha e Implantação

Prospecção

Operações

Inteligência de Mercado

Financeiro

Anexos

Macrolocalização

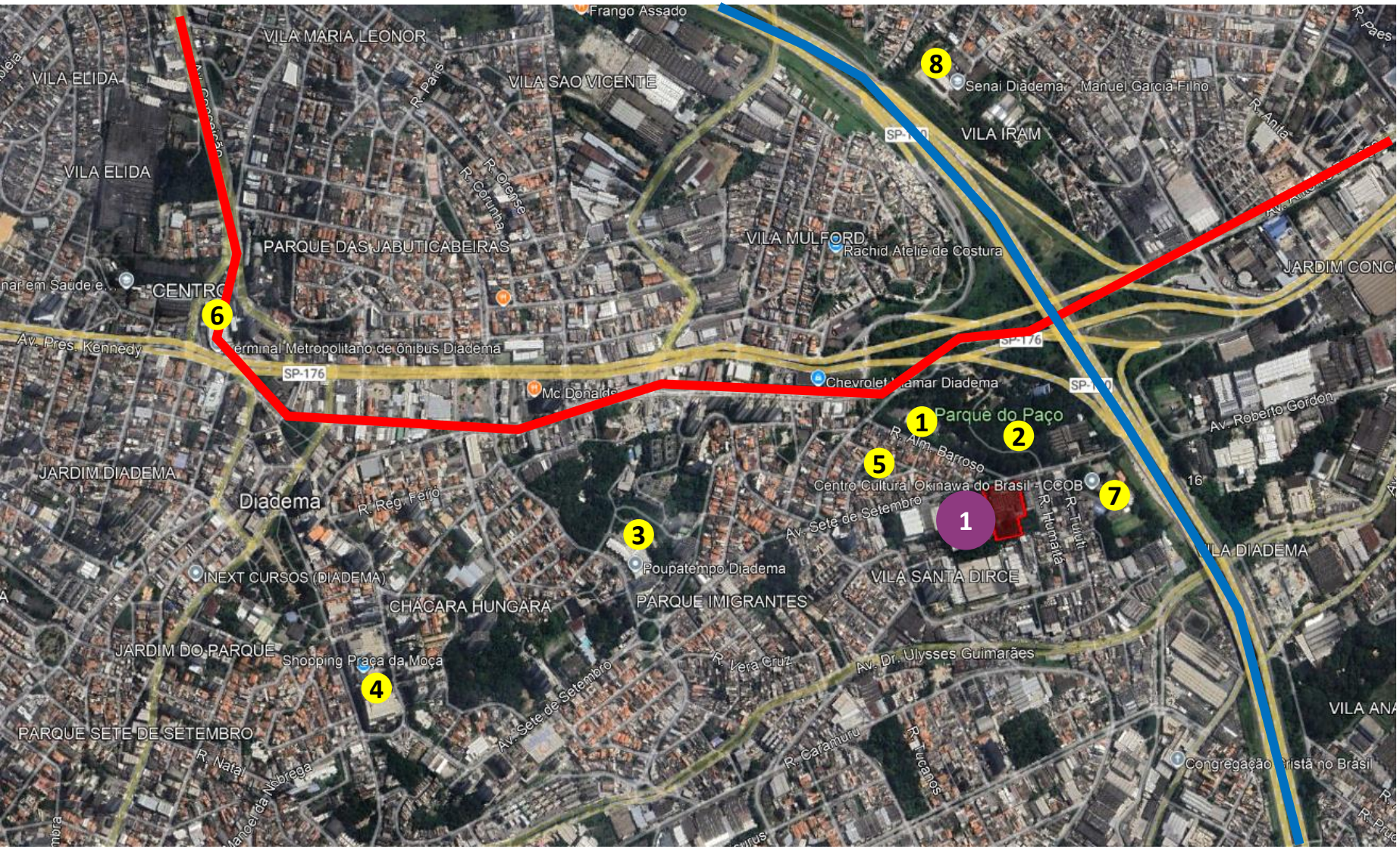

1 Prefeitura Diadema

2 Parque do Paço

3 Poupatempo Diadema

4 Shopping Praça da Moça

5 Escola Estadual

6 Terminal de ônibus metropolitano

7 Centro Cultural Okinawa

8 SENAI Diadema

Trólebus corredor ABD

Rod. Imigrantes

1 7 SETEMBRO

Localização – Av. Sete de Setembro, 1410 – Diadema - SP

Mancha de Demanda

MANCHAS DE DEMANDA
• DAM – Diadema
LandBank
1. AV. 7 DE SETEMBRO

Cluster MPR – (Comitê)
Cluster 3 - Verde

Região
Metropolitana

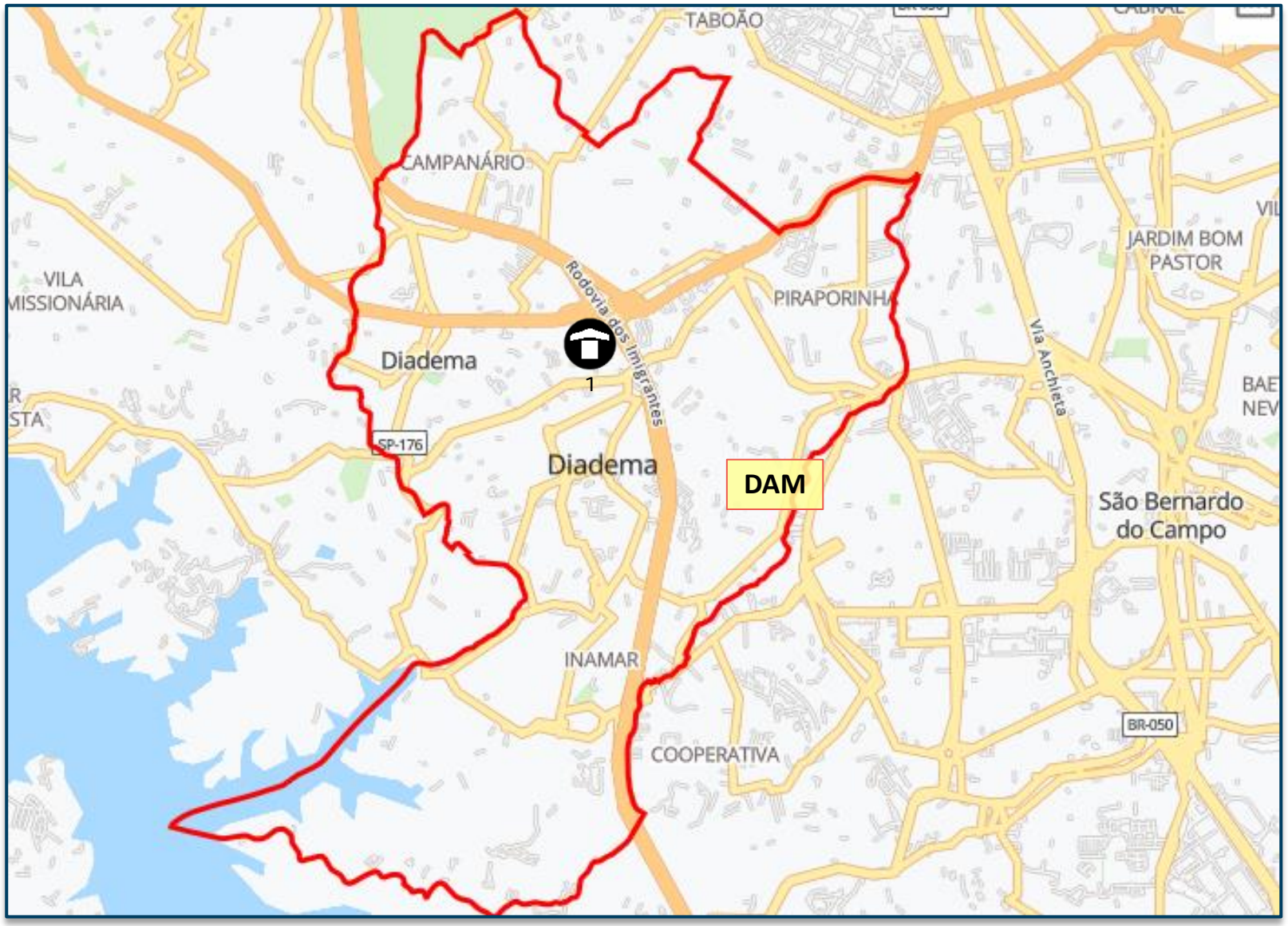

Lançados LandBank Comitê

PRODUTO

Empreendimento Sete de Setembro
Investimento

Informações Gerais – Todos os Condomínios		
Terreno	Área terreno	8.363,00m²
	Menor poligonal	8.363,00m²
	APP/FNA	Sim - 1.460,91m
	Reserva de calçada/ melhoramento viário	Não
	Área liquida	6.902,09m²
	Zoneamento	EAO
	Ca máximo	5,00
	Ca projetado	4,76
	Ca proj na área líq.	5,77*
	Gabarito máximo	T+32
Geral	Total uh	944
	Total de vagas	144 Vagas de moto

* Limite de CA Max = 5. Índice meramente enunciativo e serve para mostrar aproveitamento do terreno sobre área do terreno implantável, descontando APP.

	Considerações	Criticidade	Descrição
Material analisado	Ficha Briefing		
	Matricula		
	Planialtimétrico		
	Inexigibilidade		Em processo da prefeitura foi identificada altura máxima de 861m, porém em processo de pré-análise do DECEA foi dada inexigibilidade para T+24
	Inputs Técnicos (internos)		
	KMZ		
	Arbóreo		Identificado Pau Brasil no terreno, que, previamente alinhado com prefeitura, será suprimido pois está em situação que não permite ser transplantado nem mantido.
	Sondagem		

PRODUTO

Empreendimento Sete de Setembro
Investimento

Informações Gerais – Condomínio 01		
Terreno	Área terreno	4.348,00m²
	Menor poligonal	4.348,00m²
	APP/FNA	Sim – 999,81m
	Reserva de calçada/ melhoramento viário	Não
	Área liquida	3348,19m²
	Zoneamento	EAO
	CA máximo	5,00
	CA projetado	4,84
	Ca proj na área líq.	6,28
	Gabarito máximo	T+32
Geral	Total UH	497
	Total de vagas	66 vagas de moto
Tipologia	Tipologia	V0200
	Gabarito	T+24
	Lâmina	01 20PP
	Área privativa	32,47m² e 32,82m²
Condomínio	Unidade PCD	15
	Unidade lazer|técnica	02|01
	Torre	01
	Fase	Única
Lazer	Lazer coberto	Salão de festa gourmet interno, espaço office, Salão de festa com churrasqueira externo e churrasqueira externa
	Lazer descoberto	Fitness, Playkids, Playbaby e quadra gramada

CONDOMÍNIO 01

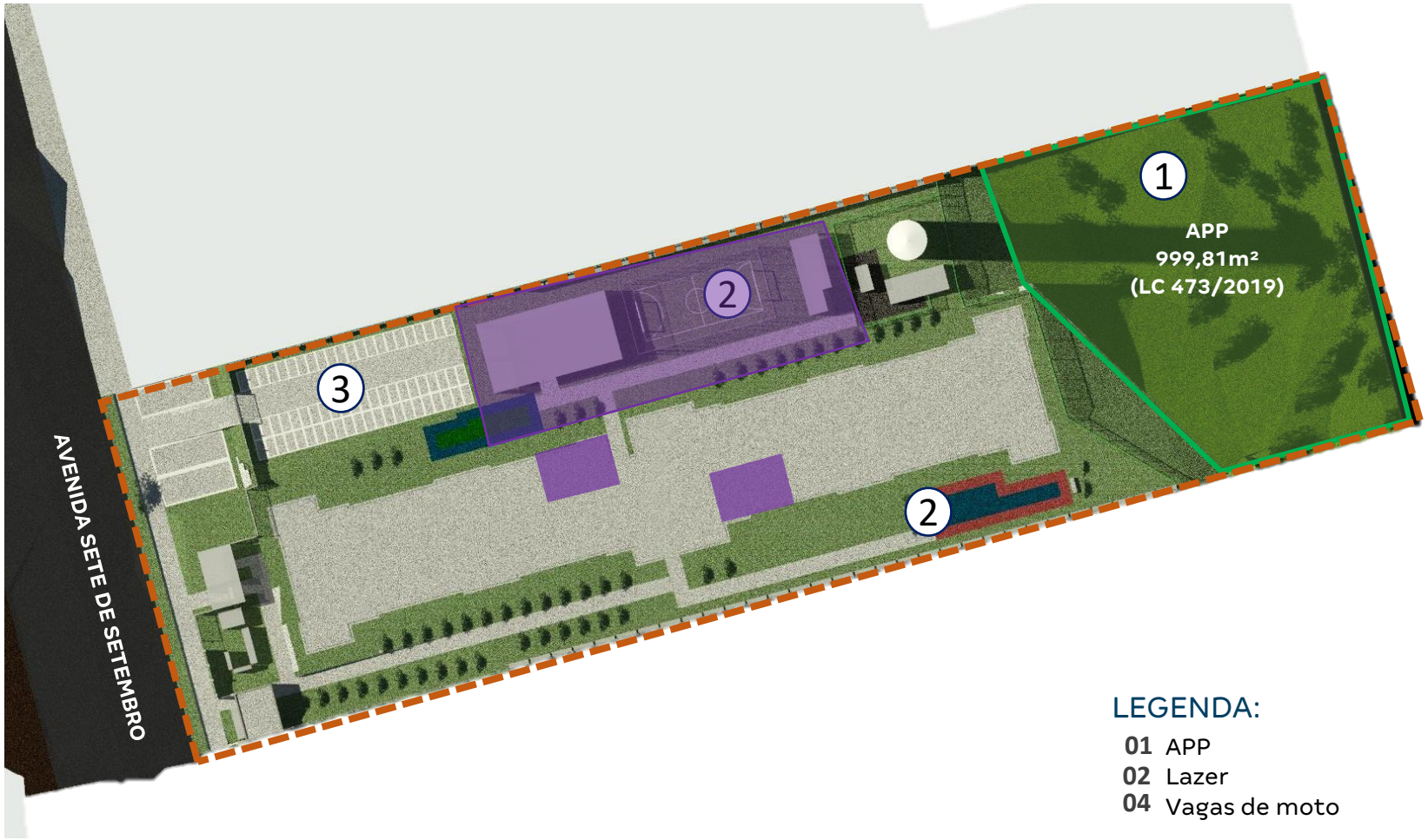

LEGENDA:

01 APP
02 Lazer
04 Vagas de moto

PRODUTO

Empreendimento Sete de Setembro
Investimento

	Descrição	Criticidade	Parecer
Usabilidade	Limite supercondomínio		
	Acesso		
	Percurso do pedestre até torre		
Diferencial produto	Atributos Infra	Sim	Quadra gramada
	Atributos Torre	Não	
	Edifício Garagem	Não	



Portaria

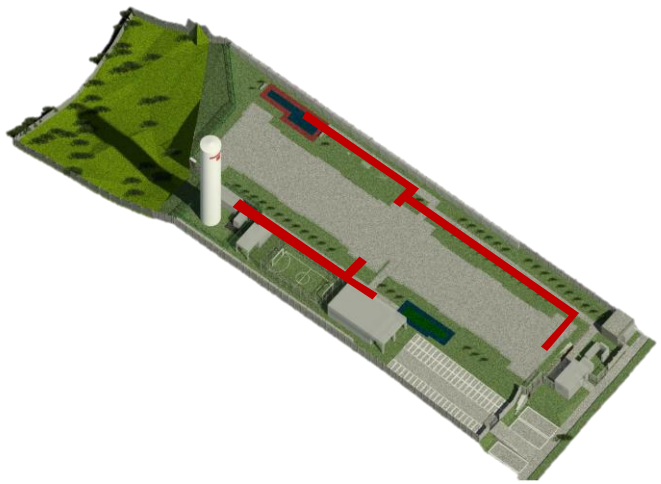

Percursos

Lazer – Quadra, salão de festas e churrasqueira

PRODUTO

Empreendimento Sete de Setembro
Investimento

Informações Gerais – Condomínio 02		
Terreno	Área terreno	4.015,00m²
	Menor poligonal	4.015,00m²
	APP/FNA	Sim - 461,10m
	Reserva de calçada/ melhoramento viário	Não
	Área liquida	3.553,90m²
	Zoneamento	EAO
	CA máximo	5,00
	CA projetado	4,69
	Ca proj na área líq.	5,29*
	Gabarito máximo	T+32
Geral	Total UH	447
	Total de vagas	78 vagas de moto
Tipologia	Tipologia	V0200
	Gabarito	T+24
	Lâmina	01 18PP
	Área privativa	32,47m² e 32,82m²
Condomínio	Unidade PCD	14
	Unidade lazer|técnica	02|01
	Torre	01
	Fase	Única
Lazer	Lazer coberto	Salão de festa gourmet interno, espaço office, Salão de festa com churrasqueira externo e churrasqueira externa
	Lazer descoberto	Fitness, Playkids, Playbaby e quadra gramada

CONDOMÍNIO 02

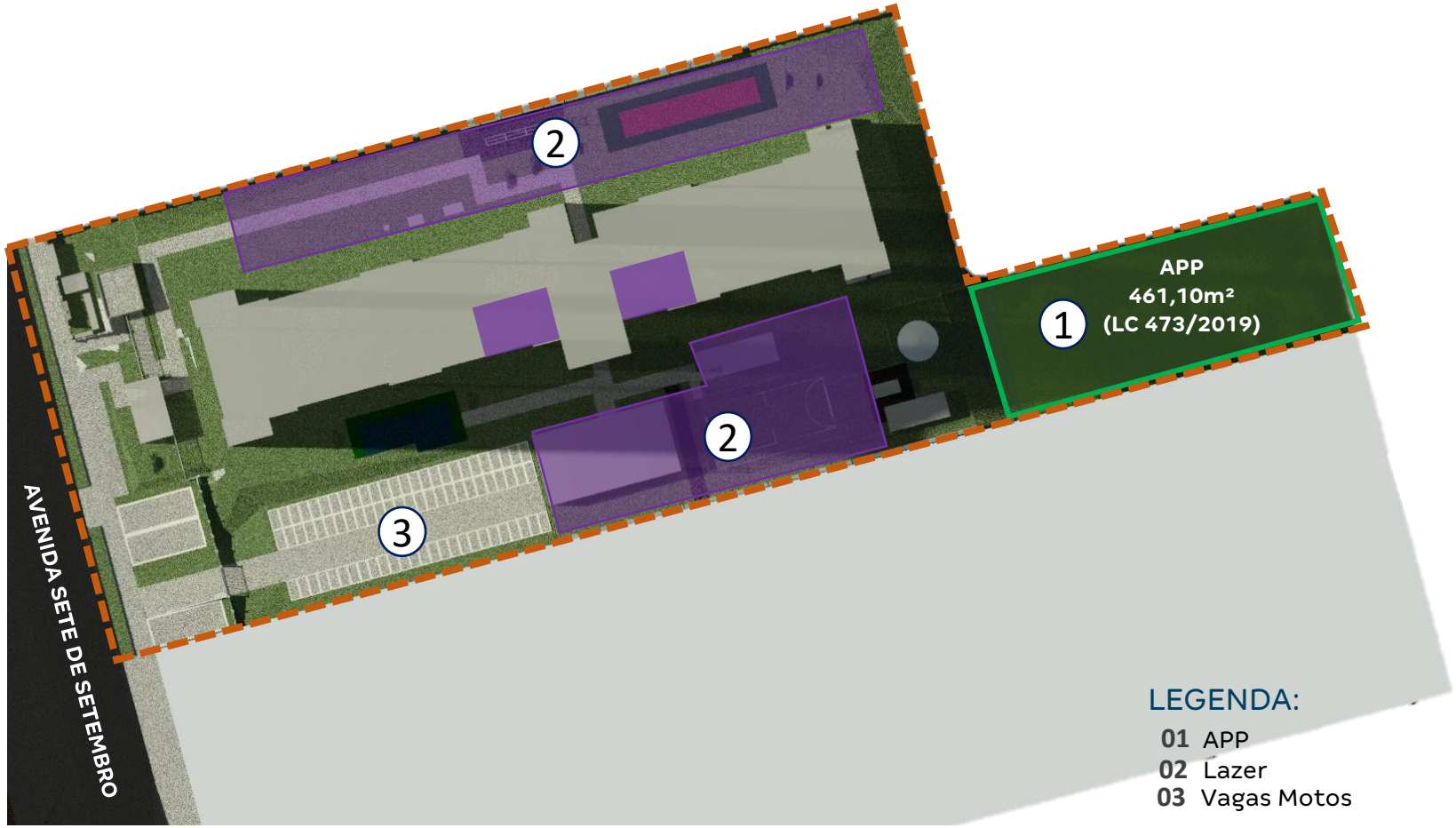

LEGENDA:

01 APP
02 Lazer
03 Vagas Motos

PRODUTO

Empreendimento Sete de Setembro
Investimento

	Descrição	Criticidade	Parecer
Usabilidade	**Limite supercondomínio**		
	Acesso		
	Percurso do pedestre até torre		
Diferencial produto	**Atributos Infra**	Sim	Quadra gramada
	Atributos Torre	Sim	Varanda na fachada leste (Voltada para o Centro Cultura Okinawa) – 48% de varanda
	Edifício Garagem	Não	

Portaria

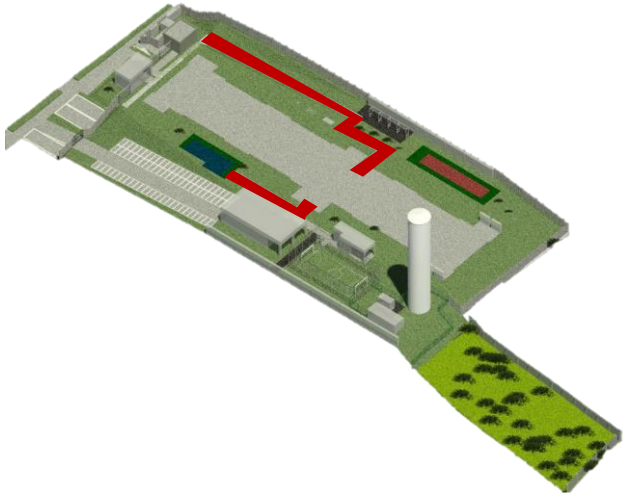

Percursos

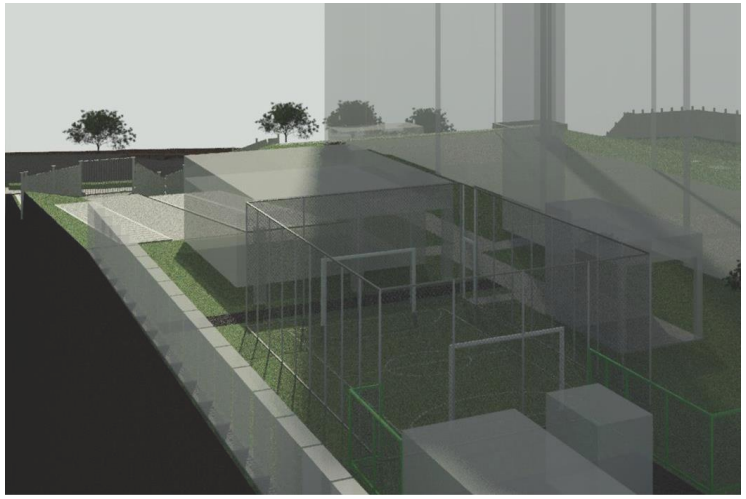

Lazer – Quadra, salão de festas e churrasqueira

Pareceres

Análise da Mancha e Implantação

Prospecção

Operações

Inteligência de Mercado

Financeiro

Anexos

Condições do negócio

VALOR DO NEGÓCIO

- R$ 14.500.000,00 - 96,3% em permuta financeira e 3,7% em dinheiro - aproximadamente R$ 364/CA proj. e R$ 1.734/m2

FORMA DE PAGAMENTO

- Sinal: R$ 540.000,00 em 18 vezes mensais fixas e irreajustáveis para pagamento de IPTU e vigilância, mediante superação das resolutivas da 1ª tranche; OBS: Valor a fundo perdido, equivalente a 0,2% do VGV;
- Saldo em permuta financeira: com mínimo garantido de R$ 13.960.000,00, com percentual a ser definido na escritura de compra e venda, com correção atrelada à variação positiva do IPCA;
    - Antecipação: Até R$3.300.000,00 destinados ao pagamento de débitos de IPTU em dívida ativa, vinculado ao momento da escritura do imóvel, ou garantido por AF se necessário em etapa anterior. O reembolso desta parcela será reajustado pela variação positiva do IPCA e abatido das primeiras parcelas de repasse da permuta financeira;

GARANTIAS

- Garantia ao pagamento: Seguro Garantia da Permuta Financeira.

ESCRITURA E POSSE

- Concomitante à superação integral das resolutivas do contrato.

CORRETAGEM

- 4% (R$580.000,00) sobre o valor total pagos em 4 parcelas, 30 dias após ECV

PRAZOS e RESOLUTIVAS:

- Primeira tranche (Técnica, Jurídica e Financeira): 180 dias (4 meses + 2 meses prorrogáveis)
- Segunda tranche (Aprovação de projeto, contratação CEF, análise técnica, financeira e comercial para o lançamento do empreendimento): 540 dias (18 meses + 18 meses prorrogáveis)
- Em caso de identificação de contaminação, as custas da remediação para uso residencial deverão ficar a cargo do vendedor, até o limite de R$ 250.000,00. OBS: análise prévia não apresentou contaminação.
- **Contrato em etapa de assinatura – Previsão 25jun – Condição para baixa de landbank**

Pareceres

Análise da Mancha e Implantação

Prospecção

Operações

Inteligência de Mercado

Financeiro

Anexos

Comitê

	7 DE SETEMBRO COND. 1 CEN. 01 | R. 02	7 DE SETEMBRO COND. 2 CEN. 01 | R. 02	7 DE SETEMBRO CONSOLIDADO CEN. 01 | R. 02	7 DE SETEMBRO CONSOLIDADO CEN. 01 | R. 01	7 DE SETEMBRO CONSOLIDADO CEN. 01 | R. 00	BELA VISTA JARAGUÁ CONSOLIDADO CEN. 03 | R. 03	CUIABINHO CEN. 01 | R. 00
Torres	1	1	2	2	2	2	2
Unidades Construídas	500	450	950	950	950	1.040	510
Unidades Vendidas	497	447	497 | 447	497 | 447	497 | 447	513 | 514	499
Total Unidades Vendidas	497	447	944	944	944	1.027	499
Condomínios (qta.)	1	2	2	2	2	1	1
Cidade	Diadema - SP	Diadema - SP	Diadema - SP	Diadema - SP	Diadema - SP	São Paulo - SP	Itaquaquecetuba - SP
Produto / Selo	F2EPlus MODULAR	F2EPlus MODULAR	F2EPlus MODULAR	F2EPlus MODULAR	F2EPlus MODULAR	F2E Plus - V0200 CDW	F2EPlus - V0200 CDW
Tipologia	1 Torre | T+24 | 20PP | CE2B		1 Torre | T+24 | 20PP | CE2B	1 Torre | T+24 | 20PP | CE2B	1 Torre | T+24 | 20PP | CE2B	2 Torres | T+25 | 20PP	1 Torre | T+25 | 10PP
Tipologia	-	1 Torre | T+24 | 18PP | CE2B	1 Torre | T+24 | 18PP | CE2B	1 Torre | T+24 | 18PP | CE2B	1 Torre | T+24 | 18PP | CE2B	-	1 Torre | T+24 | 10PP
Atributos de Projeto		216 Varandas	216 Varandas	216 Varandas	216 Varandas	-	-
Projeto Infra	AP	AP	AP	AP	AP	AP	AP
Projeto Torre	AP	AP	AP	AP	AP	AP	AP
Mês Base	junho-25	junho-25	junho-25	maio-25	maio-25	maio-25	maio-25
Incc	1.191,327	1.191,327	1191,33	1191,33	1.184,462	1.184,462	1.178,386
LVS	abril-25	abril-25	abril-25	abril-25	abril-25	março-25	março-25
Indiretos	abril-25	abril-25	abril-25	abril-25	abril-25	março-25	março-25
Base de Preço	LPU 91	LPU 91	LPU 91	LPU 91	LPU 91	LPU 90	LPU 89
Takt	2x2	2x2	2x2	2x2	2x2	2x2	2x2
Prazo (mês)	21	19	21 | 19	21 | 19	22 | 19	24 | 22	21
CUSTO TOTAL I	R$ / UND R$ 97.714	R$ / UND R$ 101.438	R$ / UND R$ 99.478	R$ / UND R$ 99.478	R$ / UND R$ 99.999	R$ / UND R$ 104.636	R$ / UND R$ 107.322
Indireto	R$ 19.050	R$ 19.684	R$ 19.350	R$ 19.350	R$ 19.873	R$ 19.807	R$ 20.598
Torre	R$ 60.705	R$ 61.952	R$ 61.296	R$ 61.296	R$ 61.295	R$ 60.505	R$ 63.125
Infra	R$ 11.405	R$ 11.505	R$ 11.453	R$ 11.453	R$ 11.453	R$ 15.144	R$ 14.438
Fundação	R$ 5.804	R$ 6.460	R$ 6.114	R$ 6.114	R$ 6.114	R$ 6.635	R$ 6.045
EEE							
ETE							
Contenção	R$ 552	R$ 1.446	R$ 975	R$ 975	R$ 975	R$ 1.140	R$ 1.324
Terraplenagem	R$ 198	R$ 391	R$ 289	R$ 289	R$ 289	R$ 1.406	R$ 1.791
CUSTO TOTAL II	R$ 4.574	R$ 4.574	R$ 4.574	R$ 216	R$ 216	R$ 4.138	R$ 1.132
Urbanização	R$ 84	R$ 84	R$ 84	R$ 84	R$ 84	R$ 129	R$ 154
Drenagem				Não considerado	Não considerado		R$ 130
Extensão de Rede Elétrica	R$ 132	R$ 132	R$ 132	R$ 132	R$ 132	R$ 122	R$ 251
Extensão de Rede Hidráulica	R$ 4.358	R$ 4.358	R$ 4.358	Não considerado	Não considerado	R$ 3.888	R$ 598
CUSTO TOTAL III							
Incorridos							
CUSTO TOTAL IV							
Aprendizado							
CUSTO TOTAL V					R$ 581	R$ 630	R$ 1.191
Atualização por INCC					R$ 581	R$ 630	R$ 1.191
CUSTO TOTAL I+II	R$ 102.289	R$ 106.012	R$ 104.052	R$ 99.694	R$ 100.216	R$ 108.775	R$ 108.454
CUSTO TOTAL I AO IV	R$ 102.289	R$ 106.012	R$ 104.052	R$ 99.694	R$ 100.797	R$ 109.405	R$ 109.645

Custo de Construção

	7 DE SETEMBRO CONSOLIDADO CEN. 01 | R. 02	7 DE SETEMBRO CONSOLIDADO CEN. 01 | R. 01	
Torres	2	2	
Unidades Construídas	950	950	
Unidades Vendidas	497 | 447	497 | 447	
Total Unidades Vendidas	944	944	
Condomínios (qta.)	2	2	
Cidade	Diadema - SP	Diadema - SP	
Produto / Selo	F2EPlus MODULAR	F2EPlus MODULAR	
Tipologia	1 Torre | T+24 | 20PP | CE2B	1 Torre | T+24 | 20PP | CE2B	
Tipologia	1 Torre | T+24 | 18PP | CE2B	1 Torre | T+24 | 18PP | CE2B	
Atributos de Projeto	216 Varandas	216 Varandas	
Projeto Infra	AP	AP	
Projeto Torre	AP	AP	
Mês Base	junho-25	maio-25	
Incc	1191,327	1191,327	
LVS	abril-25	abril-25	
Indiretos	abril-25	abril-25	
Base de Preço	LPU 91	LPU 91	
Takt	2x2	2x2	
Prazo (mês)	21 | 19	21 | 19	
CUSTO TOTAL I	R$ / UND R$ 99.478	R$ / UND R$ 99.478	DIF R$ 0
Indireto	R$ 19.350	R$ 19.350	R$ 0
Torre	R$ 61.296	R$ 61.296	R$ 0
Infra	R$ 11.453	R$ 11.453	R$ 0
Fundação	R$ 6.114	R$ 6.114	R$ 0
EEE	R$ 0	R$ 0	R$ 0
ETE	R$ 0	R$ 0	R$ 0
Contenção	R$ 975	R$ 975	R$ 0
Terraplenagem	R$ 289	R$ 289	R$ 0
CUSTO TOTAL II	R$ 4.574	R$ 216	R$ 4.358
Urbanização	R$ 84	R$ 84	R$ 0
Drenagem	R$ 0	Não considerado	R$ 0
Extensão de Rede Eletrica	R$ 132	R$ 132	R$ 0
Extensão de Rede Hidráulica	R$ 4.358	Não considerado	R$ 4.358
CUSTO TOTAL III	R$ 0	R$ 0	R$ 0
Incorridos	R$ 0	R$ 0	R$ 0
CUSTO TOTAL IV	R$ 0	R$ 0	R$ 0
Aprendizado	R$ 0	R$ 0	R$ 0
CUSTO TOTAL V	R$ 0	R$ 0	R$ 0
Atualização por INCC	R$ 0	R$ 0	R$ 0
CUSTO TOTAL	R$ 104.052	R$ 99.694	R$ 4.358

EXNTENSÃO DE REDE HIDRAULICA

+4.358 | Viabilidade emitida.

Operações

SISTEMA DE ABASTECIMENTO DE ÁGUA
Viabilidade emitida. Extensão de 430 m. Interligando na Rua Benjamin Constant.

SISTEMA DE ESGOTAMENTO SANITÁRIO
Viabilidade emitida. Extensão de 620 m. Interligando na Carlos Gomes.

SISTEMA DE DRENAGEM
Não foram emitidas Diretriz.

SISTEMA DE ABASTECIMENTO DE GÁS
Gás encanado.

SISTEMA DE ABASTECIMENTO ELÉTRICO
Não existe viabilidade técnica.

TERRENO

URBANIZAÇÃO
Considerado execução das calçadas no entorno do empreendimento.

Pareceres

Análise da Mancha e Implantação

Prospecção

Operações

Inteligência de Mercado

Financeiro

Anexos

Demanda e Distribuição da Mancha

Potencial de Demanda			Lançados		Lançados + Landbank	
Mancha	CÓD.	Shr.	ANO	MÊS	ANO	MÊS
Diadema	DAM	50%	444	37	533	44

Empreendimento	Renda	Lançamento	dez/26	jan/27	fev/27	mar/27	abr/27	mai/27	jun/27	jul/27	ago/27	set/27	out/27	nov/27	dez/27	jan/28	fev/28	mar/28	abr/28	mai/28	jun/28	jul/28	ago/28	set/28
Av. 7 de Setembro I	3.423	dez-26		28	28	28	28	28	28	28	28	28	28	28	28	28	28	28	28	28	21			
Av. 7 de Setembro II	3.423	jun-28																				25	25	25
Total de Vendas Lançados			0	0	0	0	0	0	0	0	0	0	0	0	0	0	0	0	0	0	0	0	0	0
Total de Vendas Lançados + Landbank			0	28	28	28	28	28	28	28	28	28	28	28	28	28	28	28	28	28	21	25	25	25

Parecer de I.M sobre a mancha:

O projeto analisado em comitê está em linha com o potencial teórico de demanda calculado para a mancha. (Total Lanç + Landbank)

Canibalização:

Sem Risco de Canibalização

Av. 7 de Setembro I | Mapa Concorrência

		Av. 7 de Setembro I	Condomínio Roma	Unik Imigrantes
		TENDA	SSJ	MC3
	Distância Tenda (km)		2,82Km	2,51Km
Região 1 Km	População	33.003	50.073	42.596
	Dens. Demográfica	10.573	16.042	13.646
	Renda (R$)	5.839	4.719	4.374
	Classe Social	C1 (2.7k a 4.6k)	C1 (2.7k a 4.6k)	C1 (2.7k a 4.6k)
	PEA Dia	24.527	19.786	25.220
Quantitativo	Lançamento	dez/26	08/2024	10/2024
	Unidades	497	149	349
	Estoque	497	101	133
	VSO	28	5	27
	Stockout	18	21	5
Qualitativo	Condomínios	2	1	1
	Torres	2	2	1
	Gabarito	T+24	T+11	T+18
	Plantas (m²)	2m² e 34,70m² (com varanda	42m²	37,5m² e 37,5m² e 41,5m² e 46m² e 53,5m²
	Tipologia	2 Dorms	2 Dorms	2 Dorms
	Opções	Não	Não	Garden
	Varanda	Sim	Não	Não
	Suite	Não	Não	Não
	Dif. Entrega	Não	-	-
	Vagas	13% de Vagas	100% Com vaga	100% Com vaga
	Lazer	Salão de festa gourmet, churrasqueira gourmet, quadra gramada, play baby, play kids, fitness, bicicletários verticais	Campo de Futebol, Lago, Salão de Jogos,	Tem Garden, Campo de Futebol, Cinema, Fireplace, Lago, Piscina, Piscina Aquecida, Piso Elevado, Praça, Quiosque,

Tipologias	Empreendimento	Av. 7 de Setembro I		Condomínio Roma		Unik Imigrantes	
	Tipologia	Sem vaga	Vaga Moto	Vaga Moto	Vaga Carro	Com vaga	Garden c/vaga
	Preço Nominal	236.000	244.470	253.464	311.570	311.900	365.600
	CEF	178.696	185.541	223.048	274.182	274.472	321.728
	Renda	3.399	3.577	5.490	6.640	6.640	7.790
	Dif Renda			1.913	-	-	-
	Farol de Factibilidade			●	-	-	-

Farol Renda
● Acima de 300
● Entre 0 e 300
● Abaixo de 0

Diagnóstico Concorrência

- Os concorrentes mapeados performam target de preço e renda acima do estimado no parecer.

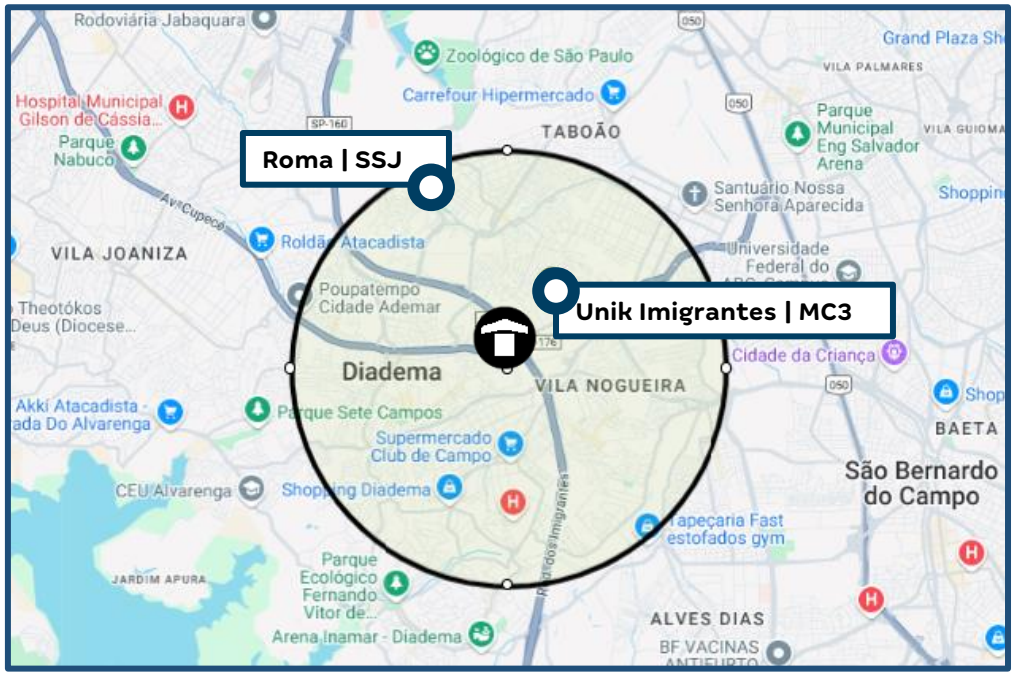

Simulação de Preço – Cond. 01

Informações Viabilidade

Projeto:	Av. 7 de Setembro I			
Tipo:	**Sem vaga**		**Vaga moto**	
Método	**Vision**		**Vision**	
Avaliação	245.000		255.000	
Renda Inicial (VF)	3.399		3.577	
Renda Final*	-		-	
% RET1	25%		25%	
Tipo:	**VF**	**R$**	**VF**	**R$**
Ato	0,81	2.768	0,77	2.768
FGTS	0,79	2.685	0,75	2.685
Financiamento	92,56%	171.608	93,64%	179.211
Subsídio	129,08%	4.404	146,51%	3.645
Prazo de Pró-soluto	26	26	26	26
Pró-Soluto	85,67%	27.508	86,22%	29.133
Preço Raso (RS)	208.973	208.973	217.442	217.442
TCD	78,89%	27.028	74,96%	27.028
VSO	24	24	4	4
Preço de Venda	**236.000**	**236.000**	**244.470**	**244.470**
Elasticidade	0,000%	0,000%	0,000%	0,000%
Preço de Venda Final	**236.000**	**236.000**	**244.470**	**244.470**
Preço Raso (R$)	**208.973**		**217.442**	
% de Raso	**88,55%**		**88,94%**	
BP25 - Não Inflacionado	-		-	
BP25 - Inflacionado	-		-	

Análise de Preço

Informações Viabilidade

Projeto:	Av. 7 de Setembro I
Tipo:	**Faixa 2**
Método	**Vision**
Avaliação	246.328
Renda Inicial (VF)	3.423
Renda Final*	-

Tipo:	VF	R$
Ato	0,81	2.768
FGTS	0,78	2.685
Financiamento	92,71%	172.617
Subsídio	131,39%	4.303
Prazo de Pró-soluto	26	26
Pró-Soluto	85,74%	27.724
Preço Raso (RS)	210.097	210.097
TCD	78,36%	27.028
VSO	28	28
Preço de Venda	**237.125**	**237.125**
Elasticidade	0,000%	0,000%
Preço de Venda Final	**237.125**	**237.125**

Preço Raso (R$)	**210.097**
% de Raso	**88,60%**
Raso Todas as Fases	**215.722**
Nominal Todas as Fases	**242.978**

1

Análise de Riscos	Farol IM
IM avalia o Preço Vision como **factível**.	

1) I.M está de acordo com o preço Vision, tendo em vista que, o projeto está em uma região com bons indicadores sociodemográficos, como renda e PEA/Dia, o mesmo também se encontra próximo de pontos de interesses como hospital, escola e etc.

Conforme consta no slide “Panorama de Concorrência”, os concorrentes da região vendem em um target de preço e renda acima do previsto para o Produto Tenda.

Simulação de Preço – Fases Futuras (Cond. 02)

Vision

Nome Fase	Tipologia	Renda	Ato	FGTS	Cond.	Subsídio	PSOL	TCD	VSO	Nom. Pré	Avali.	Elast.	Nom. Pós	Raso Pós	PSOL (m)	RET1
Av. 7 de Setembro II	Sem vaga	3.399	0,81	0,79	93,1%	129,1%	87,2%	80,3%	13	233.884	245.000	1,7857%	238.061	210.550	24	25%
Av. 7 de Setembro II	Sem vaga + varanda	3.899	1,02	0,99	94,0%	169,1%	87,2%	70,0%	8	254.194	255.000	1,7857%	258.734	231.223	24	0%
Av. 7 de Setembro II	Vaga moto + varanda	4.199	0,95	1,14	95,8%	84,1%	87,8%	65,0%	4	262.273	265.000	1,7857%	266.957	239.446	24	0%

Análise Concorrência

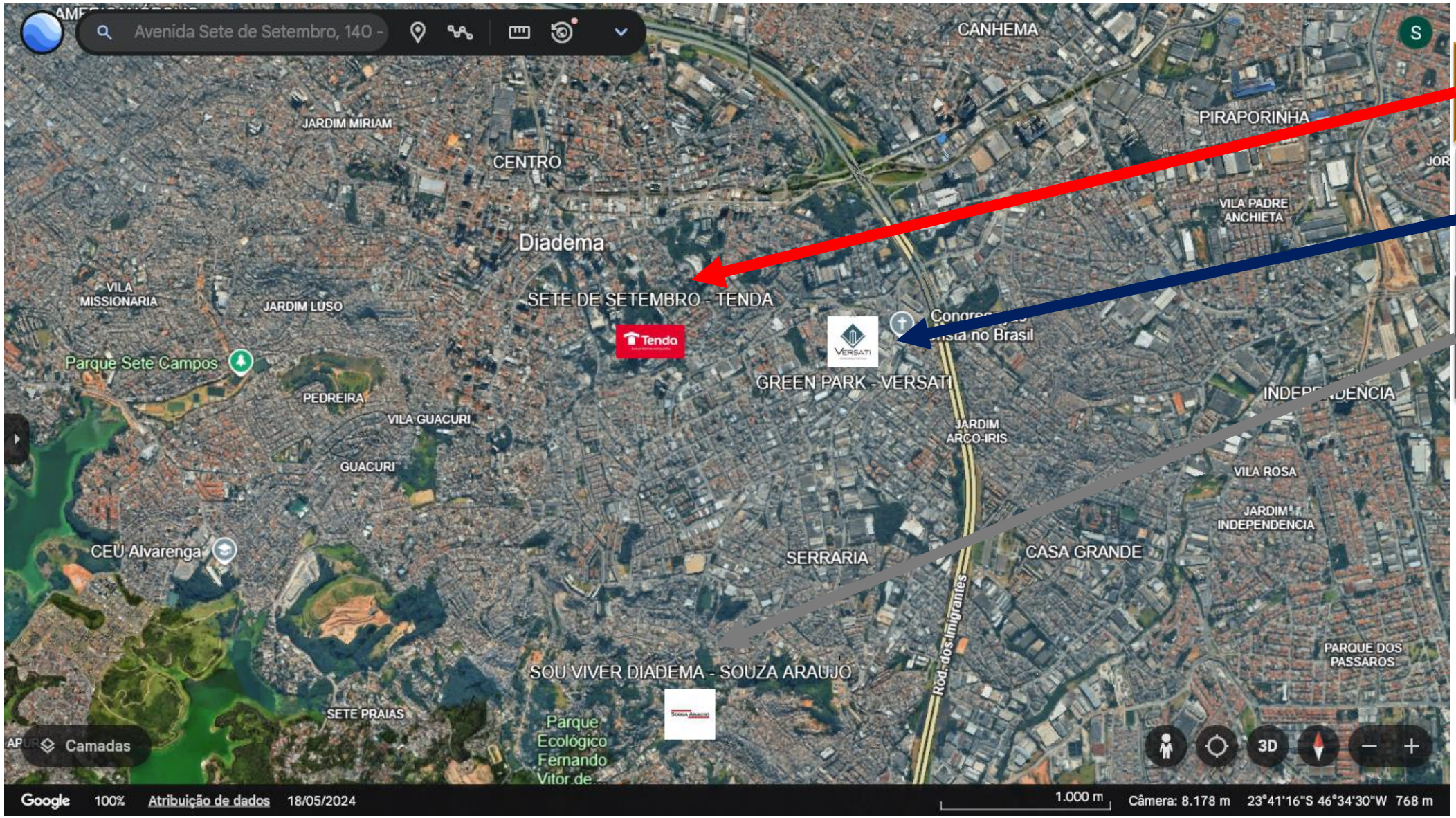

TENDA

DIADEMA

VERSATI

GREEN PARK
1 km

SOUZA ARAUJO

SOU VIVER DIADEMA
2 km

Parecer Comercial

Análise Concorrência

Concorrência 1

Incorporadora: VERSATI

Inf. Produto	Green Park
Data Lanç	24/04/2025
Qtde de unidade	320
Estoque	260
Renda Apartir	3.500
Tipologias	HIS2
Tipologias	R2V

Preço	
HIS1 - 42,90m² S/Varanda C/Vaga Moto	235.000
HIS2 - 40,09m² S/Varanda C/Vaga Carro	270.000
HIS2 - 45,82m² C/Varanda C/Vaga Moto	285.000
R2V - 43,01m² C/Varanda C/Vaga Carro	340.000
R2V - 45,82m² C/Varanda C/Vaga Carro	355.000

Fluxo	
Ato	1,25% Valor do Imovel
30/60/90	3,75% Valor do Imovel
Prazo Pró-Soluto	32
% Pró-Soluto	12% Valor do Imovel
Prazo Intermediaria	3
% Pró-Soluto	3% Valor do Imovel
ITBI/TCD	Não possui
% Parcela TCD	Não possui
Correção	INCC

Concorrência 2

Incorporadora: Sousa Araujo

Inf. Produto	Sou Viver Diadema
Data Lanç	01/02/2025
Qtde de unidade	250
Estoque	88
Renda Apartir	4.000
Tipologias	-

Preço	
43,72m² S/Vaga	273.254
44,14m² S/Vaga	278.612

Fluxo	
Ato	10% Valor do Imovel
30/60/90	Não possui
Prazo Pró-Soluto	40
% Pró-Soluto	10% Valor do Imovel
Prazo Intermediaria	0
% Intermediaria	0%
ITBI/TCD	24 Meses
% Parcela TCD	8% Valor do Imovel
Correção	INCC

Parecer do Ciclo

O Ciclo avaliou Preço e VSO como factíveis.
O projeto está em uma região de grande potencial pela escassez de lançamentos.

Pareceres

Análise da Mancha e Implantação

Prospecção

Operações

Inteligência de Mercado

Financeiro

Anexos

Informações Financeiras

Sete de Setembro, 1410 - SPRM - Região Metropolitana > 100mil SP

Datas e Prazos

	Compra	Lançamento	Início Obra	Término Obra	LÇTO até IO	IO até TO	Chaves	LÇTO até Chaves
Consolidado	jun-25							
Cond1 - Sem Vaga		dez-26	jun-27	mar-29	6 meses	21 meses	dez-29	36 meses
Cond1 - Vaga Moto		dez-26	jun-27	mar-29	6 meses	21 meses	dez-29	36 meses
Cond2 - Sem Vaga		jun-28	dez-28	jul-30	6 meses	19 meses	jun-31	36 meses
Cond2 - Sem vaga + varanda		jun-28	dez-28	jul-30	6 meses	19 meses	jun-31	36 meses
Cond2 - Vaga Moto + Varanda		jun-28	dez-28	jul-30	6 meses	19 meses	jun-31	36 meses

Terreno e Incorridos

TOTAL (R$ + Perm.):	14,50 MM	**Incorrido Terreno:** 0,00 MM	**Área do Terreno (100%):**	8.363 m²	**Área Líquida do Terreno:** 6.902 m²
Cash:	0,54 MM		**Custo de terreno m²:**	1.733,8	**Custo de terreno m² Área Líquida:** 2.100,8
Permuta Financeira:	13,96 MM (6,09%)		**VaR 25 (R$ mil):**	15	**Fração Terreno/Terreno + Custo Obra (%VGV):** 6,3% / 49,1%
Permuta Física:	0,00 MM (0,00%)		**VaR 26 (R$ mil):**	92	**CA Máx/Proj.** 5,0 / 4,8
Ato / %VGV:	0,03 MM / 0,0%		**Incorrido de Construção:**	0,00 MM	**Incorridos de Incorporação:** 0,04 MM

Vendas

Fases	Nº Pavimentos	Preço Raso Unit.	Qtde	Preço Unit.	Aval. CEF	Cond. Parcela	% Pró-soluto	% TCD
Cond1 - Sem Vaga	T+24	208.973	431	236.000	245.000	92,6%	85,7%	78,9%
Cond1 - Vaga Moto	T+24	217.442	66	244.470	255.000	93,6%	86,2%	75,0%
Cond2 - Sem Vaga	T+24	210.551	231	238.061	245.000	93,1%	87,2%	80,3%
Cond2 - Sem vaga + varanda	T+24	231.224	138	258.734	255.000	94,0%	87,2%	70,0%
Cond2 - Vaga Moto + Varanda	T+24	239.447	78	266.957	265.000	95,8%	87,8%	65,0%

Unidades Totais:	944	**Preço Médio:**	242.978	**Renda Média:**	3.551	**ITBI+Emol. Unit. Médio:**	7.129
Unidades Tenda:	944	**Avaliação Média:**	248.814	**Ato:**	3.030 (0,85 Salários)	**Custo do Ciclo Unit.:**	15.293
VSO:	28 Unidades	**VGV Total:**	229.371.302	**FGTS:**	3.004 (0,85 Salários)	**Preço Raso Médio:**	215.722
RET Médio:	3,4%	**VGV Tenda:**	229.371.302	**% em RET 1%:**	19%	**Adc. Tx. de Aceleração Médio:**	750

Construção

Custo Total Unit.:	104.051	**Eventuais:**	4,00%	**Área priv (m²):**	32,00	**Gape / Mês Unit.:**	11,08

Resultado

LI (R$):	**25.212.886**	**LI:**	**20,09%**	**Exposição de Caixa (R$):**	**17.136.029**	**Margem Bruta Econômica:**	**40,96%**
TIR:	**93,15%**	**LI Aprovação:**	**20,00%**	**Ger. Caixa 12 meses (R$):**	**(180.000)**	**Margem Bruta REF:**	**44,30%**
Exposição de Caixa:	**6,71%**	**Δ LI:**	**0,09%**	**Ger. Caixa 24 meses (R$):**	**(10.075.096)**	**Margem Rasa Econômica:**	**32,56%**
Payback Contingente (21 m):	**20 m/ (-1 m)**	**LI Resiliência:**	**13,82%**	**Ger. Caixa Marginal (R$):**	**67.392.866**	**Margem Rasa REF:**	**37,28%**
Payback Consolidado:	**20 meses**					**Margem de Contribuição Econômica:**	**28,46%**

Informações Financeiras

R$ Mil - Valores Nominais - Compra	Sete de Setembro, 1410		Cond1 - Sem Vaga		Cond1 - Vaga Moto		Cond2 - Sem Vaga		Cond2 - Sem vaga + varanda		Cond2 - Vaga Moto + Varanda	
	Nominal	%	Nominal	%	Nominal	%	Nominal	%	Nominal	%	Nominal	%
Receita	255.327	100,0%	109.370	100,0%	17.369	100,0%	63.544	100,0%	41.180	100,0%	23.864	100,0%
PIS/COFINS	(4.818)	1,9%	(1.949)	1,8%	(310)	1,8%	(1.133)	1,8%	(903)	2,2%	(523)	2,2%
Custo Total	(147.892)	59,0%	(63.148)	58,8%	(9.724)	57,0%	(38.538)	61,7%	(23.270)	57,8%	(13.211)	56,6%
Custo Terreno	(17.079)	6,8%	(6.241)	5,8%	(985)	5,8%	(4.879)	7,8%	(3.148)	7,8%	(1.825)	7,8%
Custo Relacionados a Terreno	(2.723)	1,1%	(1.203)	1,1%	(186)	1,1%	(680)	1,1%	(416)	1,0%	(237)	1,0%
Custos de Incorporação	(4.735)	1,9%	(2.077)	1,9%	(341)	2,0%	(1.188)	1,9%	(714)	1,8%	(414)	1,8%
Custo de Construção	(123.356)	49,2%	(53.627)	49,9%	(8.212)	48,1%	(31.791)	50,9%	(18.992)	47,2%	(10.735)	46,0%
Lucro Bruto Econômico	102.617	41,0%	44.273	41,2%	7.335	43,0%	23.873	38,3%	17.006	42,2%	10.129	43,4%
Custo para Rateio	-	0,0%	-	0,0%	-	0,0%	-	0,0%	-	0,0%	-	0,0%
Lucro Bruto Contábil	102.617	41,0%	44.273	41,2%	7.335	43,0%	23.873	38,3%	17.006	42,2%	10.129	43,4%
Despesas de Selling	(25.447)	10,2%	(10.955)	10,2%	(1.725)	10,1%	(6.343)	10,2%	(4.057)	10,1%	(2.366)	10,1%
Contingência	(5.873)	2,3%	(2.516)	2,3%	(399)	2,3%	(1.462)	2,3%	(947)	2,4%	(549)	2,4%
Margem de Contribuição	71.298	28,5%	30.803	28,7%	5.210	30,5%	16.068	25,7%	12.002	29,8%	7.214	30,9%
IR e CSLL	(3.942)	1,5%	(1.595)	1,5%	(253)	1,5%	(927)	1,5%	(739)	1,8%	(428)	1,8%
Margem Líquida	67.356	26,9%	29.208	27,2%	4.957	29,1%	15.142	24,3%	11.263	28,0%	6.786	29,1%
Lucro Bruto REF Unit.	123.129	44,3%	115.992	44,4%	124.520	46,1%	117.895	41,6%	140.493	45,6%	150.546	47,3%
Lucro Raso REF Unit.	91.915	37,3%	86.119	37,2%	94.698	39,4%	85.182	34,0%	107.809	39,2%	117.784	41,2%

R$ Mil - VPL - Compra	Sete de Setembro, 1410		Cond1 - Sem Vaga		Cond1 - Vaga Moto		Cond2 - Sem Vaga		Cond2 - Sem vaga + varanda		Cond2 - Vaga Moto + Varanda	
	VP	%	VP	%	VP	%	VP	%	VP	%	VP	%
Receitas	125.503	100,0%	60.435	100,0%	9.606	100,0%	27.378	100,0%	17.852	100,0%	10.232	100,0%
PIS/COFINS	(2.317)	1,8%	(1.061)	1,8%	(169)	1,8%	(481)	1,8%	(386)	2,2%	(221)	2,2%
Custos e Despesas Totais	(97.973)	78,1%	(46.604)	77,1%	(7.220)	75,2%	(22.507)	82,2%	(13.799)	77,3%	(7.843)	76,7%
Custo Terreno	(8.390)	6,7%	(3.276)	5,4%	(515)	5,4%	(2.291)	8,4%	(1.467)	8,2%	(841)	8,2%
Custo Relacionados a Terreno	(2.063)	1,6%	(912)	1,5%	(141)	1,5%	(515)	1,9%	(315)	1,8%	(180)	1,8%
Custos de Incorporação	(2.724)	2,2%	(1.313)	2,2%	(218)	2,3%	(611)	2,2%	(369)	2,1%	(213)	2,1%
Custo de Construção	(66.316)	52,8%	(32.179)	53,2%	(4.928)	51,3%	(15.095)	55,1%	(9.018)	50,5%	(5.097)	49,8%
Despesas de Selling	(15.044)	12,0%	(7.320)	12,1%	(1.163)	12,1%	(3.263)	11,9%	(2.096)	11,7%	(1.203)	11,8%
Contingência	(1.541)	1,2%	(737)	1,2%	(117)	1,2%	(339)	1,2%	(220)	1,2%	(127)	1,2%
IR e CSLL	(1.896)	1,5%	(868)	1,4%	(138)	1,4%	(393)	1,4%	(316)	1,8%	(181)	1,8%
Lucro Imobiliário	25.213	20,1%	12.770	21,1%	2.218	23,1%	4.390	16,0%	3.667	20,5%	2.168	21,2%

Pareceres

Análise da Mancha e Implantação

Prospecção

Operações

Inteligência de Mercado

Financeiro

Anexos

AMBIENTAL + LEGALIZAÇÃO – Paramétrico de custos

Orçamento Global Licenciamento	Valor total
Taxas e Emolumentos de Prefeitura	R$ 15.000,00
Plantio Arbóreo	R$ 103.950,00
Plantio Arbóreo - Cetesb	R$ -
Licenciamento e remediação contaminação - Cetesb	R$ 175.000,00
NBR 12.721 - Incorporação	R$ 5.000,00
Serviços	R$ 10.000,00
Graprohab	R$ -
Topografia	R$ 17.000,00
Contrapartida/Outorga onerosa	**Valor total**
EIV + Contrapartida	R$ 1.065.575,79
Outorga onerosa	R$ -
Valor total	**R$ 1.391.525,79**

Considerado valor para Avaliação de Qualidade Ambiental e valor para protocolo Cetesb para CEF

LC 473/19 – Art. 173 - § 3º - Inciso III "2% (dois por cento) do custo global, no caso dos empreendimentos habitacionais de interesse social nas subcategorias HIS 1 e 2" ***OBS: considerado na viabilidade o valor indicado de aproximadamente 1,06MM***

Art. 96 - § 4º "Ficam dispensados de pagamento da contrapartida financeira relativa a **Outorga Onerosa do Direito de Construir** os Empreendimento Habitacional de Interesse Social – EHIS enquadrados nas subcategorias de uso HISh e HISv bem como a subcategoria HMP promovidas exclusivamente por associações de moradia e movimentos de moradia."

JURÍDICO – Paramétrico de custos

LC 599/24 - Art. 4º "Os Empreendimentos Habitacionais de Interesse Social abrangidos por esta Lei Complementar ficam isentos dos seguintes encargos: (...)
IV - IPTU - Imposto sobre a Propriedade Predial e Territorial Urbana, a partir da data da aquisição do imóvel para incorporação de empreendimento habitacional de interesse social, até o exercício da entrega das unidades habitacionais."

DADOS	
Quantidade Unidades	944
Área Construída	37.524 m²
Tem SQL?	SIM
Valor do carne de IPTU	R$ -
Área de Matrícula	8.284
Retificação?	NÃO
Quantos Condomínios?	2
Quantos Proprietários de terreno?	4
Parcelamento do Solo?	S/ DOAÇÃO
Remembramento de Matrículas?	NÃO
Com qual valor o terreno será escriturado?	R$ 14.500.000

ABERTURA	$ FINAL		MÉTRICA
Desdobro de IPTU	R$	5.000	R$ 2.5k/ condomínio
Instituição de Condomínio	R$	1.180.000	R$ 1250/uh
Averbação da Construção	R$	283.681	Área Construída(m²) X 4 meses de Cobrança X Índice Histórico (atual 1,79/m²)
Procuração Societária	R$	5.000	5k fixo
IPTU (Anual)	R$	-	Valor do caner vigente de IPTU ou em caso de não tenha IPTU, considerado para calculo área da matrícula X Índice Histórico (atual 1,79/m²)
Registro de Incorporação	R$	198.240	R$ 210/uh + 40k quando houver necessidade de retificação
Honorário Incorporação	R$	-	Não gastamos mais com honorários de incorporação Considerado IPTU Retroativo por não ter SQL: $ IPTU X 5 anos
Cópias e Autenticações	R$	15.000	15k fixo
Honorário Aquisição	R$	120.000	120k - 2 ou mais proprietários do terreno 80k - 1 proprietário do terreno
Registro de Escritura	R$	108.750	Valor do terreno X 0,75%
ITBI Terreno	R$	435.000	Valor do terreno X 3%
Total	**R$**	**2.350.671**	**R$ 2.490/uh**

LC 472/19 - "VI - 1,5% (um inteiro e cinco décimos por cento) sobre o restante do valor não financiado e para as demais transmissões a qualquer título de imóveis de valor superior a R$ 400.000,00 (quatrocentos mil reais). "

Comentários Jurídicos – Ajustes após validação do Jurídico.

Instituição de Cond.: R$ 1.123.485,66
Registro de Incorporação: R$ 198.240,00 + R$ 40.000,00
Valor total estimado: R$2.334.156,66

CRONOGRAMA PRÉVIO

7 de Setembro	jun/25	jul/25	ago/25	set/25	out/25	nov/25	dez/25	jan/26	fev/26	mar/26	abr/26	mai/26	jun/26	jul/26	ago/26	set/26	out/26	nov/26	dez/26	out/26	nov/26	dez/26
	1	2	3	4	5	6	7	8	9	10	11	12	13	14	15	16	17	18	19	17	18	19
PROSPEC - Comitê de compra	1																					
PROSPEC LEG DPP - Baixa LB / Reunião de Passagem		1																				
PROSPEC - Emissão diretriz urbanística		1																				
LINHA - PRE-KIT processo único			1	2	3	4	5	6														
LINHA - Elaboração PL Processo B					1																	
LINHA - Elaboração PL									1													
LEG - PL e memo Desdobro			1																			
LEG - Aprovação Desdobro				1	2	3	4	5	6	7	8	9	10	11	12							
JUR - Registro Desdobro															1							
LEG - Aprovação EIV +Termo de compromisso															1	2	3					
LEG - Alvará de aprovação e execução													1	2	3	4	5	6				
NEG - NBR																		1				
LEG - Dispensa de GRAPROHAB																			1			
JUR - Registro Incorporação																			1	2		
CRE - Contratação CEF																		1	2	3	4	
NEG - Lançamento																						1

PARECER PRÉVIO – Jurídico Imobiliário

- **DESCRIÇÃO DO IMÓVEL:** Av. Sete de Setembro nº 1410, objeto da matrícula nº 45.116 do 1º Cartório de Registro de Imóveis da Comarca de Diadema/SP, cadastrado junto à Prefeitura Municipal de Diadema sob contribuinte n. 2005407900 ("**Imóvel**").

- **PROPRIETÁRIOS TABULARES: MANUEL SEQUEIRA JUNIOR e NIRYAN FLORISBELLA OLIVEIRA SEQUEIRA,** falecidos em 31.03.2020 e 16.08.2016, respectivamente.

- **HERDEIRAS (Futuras Proprietárias):** Natânia do Carmo Oliveira Sequeira, Numara Oliveira Sequeira Ponzini, Niryan Oliveira Sequeira Rapp e Nils Oliveira Sequeira.

- **CONSIDERAÇÕES JURÍDICAS SOBRE O IMÓVEL: (a) Retificação:** Em estudo técnico realizado pela Castro Topografia em 30/05/2025 foi apurada a necessidade de retificação pelo inciso I em decorrência do imóvel ser objeto de desdobro; **(b) Loteamento:** Será investigado se os imóveis são de origem de um loteamento e em caso positivo verificaremos eventuais restrições (aguardando certidões do imóvel até origem); **(c) Desmembramento:** Necessário seguir com o desmembramento da área perante prefeitura e Registro de Imóveis para obtenção de 2 áreas; **(d) Área construída:** Necessária apresentação de certidão especifica municipal em Due Diligence para apuração de divergência apuradas na matrícula e na certidão de dados cadastrais; **(e) Ocupação**: Imóvel sob a guarda das herdeiras; **(f) CONDEPHAAT, CONPRESP, IPHAN, Desapropriação e Melhoramento e Função Social da Propriedade:** Serão apurados durante a Due Diligence. **g) Ônus e Gravames**: Não constam ônus ou gravames. **h) IPTU: R$ 3.479.716,75,** dos quais: R$ 242.829,46 não inscrito em dívida ativa (2025); R$ 896.955,21, inscrito em dívida ativa sem cobrança ajuizada (2022 a 2024) e R$ 2.339.742,24 inscrito em dívida ativa com cobrança ajuizada (2013 a 2020) em duas execuções fiscais. **i) Regularização da Cadeia Dominial:** a aquisição deverá ficar condicionada ao registro das partilhas dos proprietários tabulares. O inventário judicial está em fase avançada, contudo, para acelerar os trâmites, o partilha será encerrada pela via extrajudicial, conforme petição protocolada pelas herdeiras nos autos anexando a minuta da escritura de inventário e partilha, declarações de ITCMD e requerendo a liberação dos valores depositados em conta judicial, para fins de recolhimento do ITCMD e consequente encerramento dos inventários pela via extrajudicial.

- **CONSIDERAÇÕES DD PRÉVIA –**

- **A) PROPRIETÁRIOS TABULARES (MANUEL E NYRIAN – ESPÓLIOS)**: 3 ações ajuizadas pelo Banco do Brasil em fase de cumprimento de sentença:
  - Proc. nº 1012039-19.2020.8.26.0161: valor de causa atualizado: R$ 2.046.579,87
  - Proc. nº 0003330-75.2021.8.26.0161: valor de causa atualizado: R$ 1.174.059,84
  - Proc. nº 0008214-50.2021.8.26.0161: valor de causa atualizado: R$ 2.027.784,40
  - **Passivo total contingenciado: R$ 5.248.424,11**

- **B) HERDEIRAS:** 01 apontamento ajuizado em face de Natânia, relativo a ação do Banco do Brasil (Proc. nº 1012039-19.2020.8.26.0161), abrangida no passivo contingenciado acima apontado para Niryan Florisbella e Manuel Sequeira.

C) EMPRESA DOS PROPRIETÁRIOS TABULARES: NILLO ADMINISTRACAO DE BENS MOVEIS LTDA. – EM RECUPERAÇÃO JUDICIAL ("RJ"):

Dívidas inseridas na RJ: para o término da RJ restam pendentes: (a) a quitação da dívida existente junto ao Banco do Brasil, objeto de cobrança nas 3 ações ajuizadas em face dos espólios (supramencionadas). Atualmente, as herdeiras vêm realizando tratativas visando a composição de acordo amigável para negociar a forma de quitação da dívida; (b) a resposta da CEF e da Activas Plásticos Industriais com intuito de formalizar a quitação da dívida noticiada nos autos pelas herdeiras; (c) arbitramento definitivo dos honorários do administrador judicial, cuja pendência não obsta o encerramento, mas deve ser tratada antes da extinção do processo.

Dívidas não inseridas na RJ: dívidas fiscais – a) 05 Execuções Fiscais - ICMS: R$ 3.699.169,10; **b)** 02 Execuções Fiscais - Contribuições Previdenciárias - INSS: R$ 7.719.299,71; **c)** 02 Execuções Fiscais - IPI: R$ 12.703.260,72; **d)** 02 Execuções Fiscais - Tributos Federais: R$ 4.137.012,57. O risco decorrente de tais execuções fiscais será verificado no âmbito da due diligence, após a análise da íntegra dos processos. Contudo, com base nos andamentos cadastrados no TJ, não foi identificado pedido de desconsideração da personalidade jurídica OU de redirecionamento das execuções para os sócios, de modo que, se confirmado esse cenário e mantido até a escritura, referidas execuções não possuem o condão de impactar a aquisição pretendida.

D) ANÁLISE DE RISCOS E CONCLUSÃO PRÉVIA: Em que pese o passivo total contingenciado é possível concluir que:

Da transferência do Imóvel dos espólios para as herdeiras: Compõem o patrimônio dos espólios: 4 imóveis cujos valores venais perfazem o montante de R$ 4.161.411,00 e o Imóvel objeto da aquisição, com valor de mercado de R$ 14.500.000,00. Portanto, em que pese o passivo identificado para os espólios, a partilha para as herdeiras não possui o condão de colocar os espólios em estado de insolvência, visto que o patrimônio é superior ao valor do passivo contingenciado (o qual engloba o passivo dos espólios, da herdeira Natânia e o passivo da Empresa Nillo abrangido pela RJ).

Da venda do Imóvel das herdeiras para a Tenda: Não foi identificado passivo em nome das herdeiras. Contudo, uma vez concluída a partilha, a dívida dos espólios (hoje no valor de **R$ 5.248.424,11)** será transferida para as herdeiras, assim como os imóveis que compõem o patrimônio dos espólios e as quotas da empresa recuperanda. Por ocasião da venda do Imóvel para a Tenda, se o cenário atual envolvendo passivo x patrimônio for mantido, remanescerá em nome das herdeiras o patrimônio de **R$ 4.161.411,00**, considerando valores venais atribuídos atualmente para os imóveis**.** Portanto, por ocasião da venda do Imóvel para a Tenda, o patrimônio que existirá em nome das herdeiras deverá ser superior ao passivo apurado em tal ocasião**. Com a assinatura do CVC e conclusão da auditoria, é recomendável estabelecer com as herdeiras medidas que visem a manutenção do cenário atualmente identificado, como forma de mitigar riscos de insolvência e/ou remediar prejuízos caso seja constatada insolvência até a data da escritura.**

LEGALIZAÇÃO

➢ **ÁREA DE IMPLANTAÇÃO**

- O terreno é composto por 1 matrícula 45.116 (2 ORI), em nome de pessoa física, e totaliza uma área 8.363,00m² escriturária.
- Area real de 8.417,00m² .
- O cadastro do imóvel é urbano;
- Importante entender a necessidade de mudança do uso e tipo da construção, pois está como industrial no IPTU

➢ **DIRETRIZES URBANÍSTICAS**

- Aguardando emissão de diretriz urbanística; estamos em conversas diretamente com Secretário de Habitação.

LEGALIZAÇÃO E DPP

➢ **GRAPROHAB**

- Aguardando diretriz SABESP para verificar a necessidade de reforço para posteriormente aprovação do projeto.
- Considerar a dispensa de GRAPROHAB em cronograma ou confirmar a necessidade junto ao cartório.

➢ **AVALIAÇÕES AMBIENTAIS**

Arbóreo

- Conforme análise, o terreno **não** é considerado como Patrimônio Ambiental
- Não incide sobre o terreno VPP;
- Não Incide sobre o Terreno Fragmento Florestal;
- Pelo cadastramento arbóreo constam 117 indivíduos isolados, 114 no interior do imóvel e 3 na calçada.

Destes, 72 indivíduos são de origem nativa, 37 são de origem exótica e 8 exemplares mortos;

- Há 1 exemplar ameaçado de extinção, pau brasil, mas para o município entra no cômputo de compensação conforme DAP, sem diferenciação entre em extinção, exóticas ou nativas;
- A propriedade não está inserida em Área de Patrimônio Ambiental (APA), Área de Proteção de Mananciais (APRM) e Unidade de Conservação;
- Cenário considera a supressão de 46 exemplares localizados no interior do lote compensação por DAP
- Compensação por DAP se plantio 224 mudas, se doar mudas à Secretaria de Meio ambiente 651 mudas.
- Considerado APP por declividade

LEGALIZAÇÃO E DPP

Hidrografia

- O Imóvel não apresenta corpos d'água internos ao perímetro ou próximo;
- Córrego mais próximo a 240m do terreno

➢ **COMAER**

- Emitido declaração de inexigibilidade do Comaer
- Altitude do topo: 885,72 m (altura 75,72m)

➢ **AVALIAÇÕES AMBIENTAIS**

Contaminação

1- RT 9326 para 28/05/2025

➢ **AVALIAÇÕES AMBIENTAIS**

Conclusão:

0- Terreno contaminado: não

1- Plano de Intervenção: NA

2- Campanhas de monitoramento: NA

3 – Necessidade de atenção: NA

4 – Vinculo inicio de obra ou habite-se: NA

Obs.: Não foi considerada remediação da área. Os resultados foram favoráveis, entenderemos junto a CETESB a necessidade de seguir com uma confirmatória.

LEGALIZAÇÃO E DPP

- **ÓRGÃOS DE PATRIMÔNIO HISTÓRICO**

- Municipal – Protocolo feito em 08/05/2025
- Estadual – Condephaat: Isento de deliberação conforme consulta ao IDESP;
- Federal – IPHAN: - Aguardando
- Confirmação com a emissão da Diretriz Urbanística de que não haverá envoltória de conservação com o Parque do Paço em frente.

- **ABASTECIMENTO SANITÁRIO**

- Diretrizes SABESP emitida solicitando reforço de rede.

- **CONTRAPARTIDA**

- Haverá cobrança de medida mitigadora em função da aprovação do HIS1-2, sendo 2% do custo de construção – contemplado na viabilidade

- **MOVIMENTAÇÃO DE TERRA**

- Aguardar a necessidade caso haja contaminação no terreno, e solicitar NBR 10.004
- Entender a necessidade de aprovação do projeto de terraplenagem junto a prefeitura municipal.

- **OUTROS ITENS NECESSÁRIOS/ESPECÍFICOS**

- Verificar junto ao município a necessidade de projetos complementares.

Obrigado