Tenda

sua próxima conquista

Book de Investimento - Respostas

Regional: RJ

Projeto: Elevato Av. Brasil – RZN2

Data Comitê: 23/06/2025

Questionamentos Comitê 16/06/2025

Nome	Elevato Av. Brasil - Investimento	Observação - Elevato Av. Brasil
Andre Luis Menegazzo Padilha	Aprovado	ok
Alexandre Regis de Oliveira	Aprovado	Ok
Renan Barbosa Sanches	Discutir em Comitê	Poderiam por favor dar mais detalhes acerca dos próximos passos da confirmação da caducidade do processo de desapropriação? Quando teremos conforto em relação a este aspecto? Idem sobre a convicção de quais medidas deverão ser tomadas para superar a contaminação. informar se projeto terá mix de varanda e senao, qual o motivo...
Alejandro Octavio Abiusi	Discutir em Comitê	Gostaria de ouvir o Ciclo sobre a convicção de praticar os 209k de raso com 27 unidades de VSO na região.
Fabricio Quesiti Arrivabene	Aprovado	ok
Luiz Mauricio de Garcia Paula	Discutir em Comitê	terreno bem complexo quanto ao due dilligence e legalização. Consta que o valor depositado em Escrow só será liberado ao Vendedor após a baixa dos gravames e assinatura da AF em favor da Tenda com o imóvel em garantia, mas quanto a contaminação e aos demais riscos de legalização? Perderemos o sinal se esses não forem superados?
Amanda da Silva Bezerra	Aprovado	Ok
Rodrigo Osmo	Discutir em Comitê	(1) Se entendi corretamente, esse projeto será lançado junto com o Elevato Ramos, que é vizinho e será precificado exatamente igual. Por que acreditamos que conseguimos ter bons VSOs em dois projetos tão semelhantes ao mesmo tempo?

Questionamentos

Renan Barbosa Sanches: *Poderiam por favor dar mais detalhes acerca dos próximos passos da confirmação da caducidade do processo de desapropriação? Quando teremos conforto em relação a este aspecto? Idem sobre a convicção de quais medidas deverão ser tomadas para superar a contaminação. informar se projeto terá mix de varanda e senao, qual o motivo...*

Resposta:

Desapropriação: A caducidade do decreto de desapropriação foi confirmada através de parecer da Procuradoria e da Secretaria de Fazenda em mai/25 e a anotação foi retirada do Relatório de Informações Urbanísticas, permitindo o licenciamento no terreno. Faltou atualizar o farol com essa informação.

Contaminação: A primeira campanha de monitoramento foi realizada em mar/25 e indicou que a contaminação existente no terreno não oferece risco à saúde humana e a recomendação é que não haja captação de água para consumo e que sejam usados EPIs durante as escavações do terreno. A segunda campanha de monitoramento será realizada em jun/25 e a expectativa do consultor é que os índices permaneçam favoráveis. Trata-se de processo semelhante ao que passamos em outros terrenos onde havia suspeita de contaminação e consideramos que é muito baixa a probabilidade de serem encontradas concentrações que excedam os índices aceitáveis e que demandem remediação do terreno.

Varandas: Nesse projeto em especial a varanda pode ser um pouco mais complicada de implantar pois as melhores faces, possuem a necessidade de caixilho acústico nível 3 e classe especial (frente Av. Brasil). É desejável e estamos tentando buscar uma solução, mas pode ser uma solução onerosa nesse caso e precisamos aprofundar, o que será feito após a passagem de bastão para negócios.

Questionamentos

Luiz Mauricio de Garcia Paula: *terreno bem complexo quanto ao due dilligence e legalização. Consta que o valor depositado em Escrow só será liberado ao Vendedor após a baixa dos gravames e assinatura da AF em favor da Tenda com o imóvel em garantia, mas quanto a contaminação e aos demais riscos de legalização? Perderemos o sinal se esses não forem superados?*

Resposta: Em caso de rescisão em razão da não superação das resolutivas, incluindo contaminação e aprovação do projeto, o sinal será 100% devolvido. Ainda, conforme contrato (item 3.8.1), caso o imóvel esteja contaminado e a Tenda não opte pela rescisão, os custos para remediação serão da vendedora, podendo ser, desde que previamente acordado, descontados do preço.

Alejandro Octavio Abiusi: *Gostaria de ouvir o Ciclo sobre a convicção de praticar os 209k de raso com 27 unidades de VSO na região.*

Resposta: Tendo em vista a localização diferenciada, com ampla frente para Av. Brasil (via arterial com farta oferta de transporte e mobilidade), e comparando com ofertas anteriores da concorrência, estamos confiantes com a proposta de preço (209k) e VSO (27) para esse projeto.
Vale ressaltar que o Elevato Av. Brasil e Elevato Ramos não serão vendidos concomitantemente de forma que o mix de produtos estabeleça uma escadinha de preço/renda respeitando o limite da demanda potencial da mancha.

Questionamentos

Rodrigo Osmo: *(1) Se entendi corretamente, esse projeto será lançado junto com o Elevato Ramos, que é vizinho e será precificado exatamente igual. Por que acreditamos que conseguimos ter bons VSOs em dois projetos tão semelhantes ao mesmo tempo?*

Resposta: Nesse caso o Elevato Av. Brasil é um coringa na mesma linha de produto do Elevato Ramos, lançaremos o que legalizar primeiro. Quando os processos de legalização forem evoluindo e tivermos convicção do primeiro lançamento buscaremos uma renegociação de prazos, no segundo lançamento, para adequar ao esgotamento, porém, seguindo a ideia de robustez e coringas na ZN, acreditamos ser importante ter essa redundância no momento.

Empreendimento	Renda	Lançamento	jun/25	jul/25	ago/25	set/25	out/25	nov/25	dez/25	jan/26	fev/26	mar/26	abr/26	mai/26	jun/26	jul/26	ago/26	set/26	out/26	nov/26	dez/26	jan/27	fev/27	mar/27	abr/27	mai/27	jun/27	jul/27	ago/27	set/27	out/27	nov/27	dez/27
Lançados																																	
Elevato Bonsucesso	3.444		21	21	21	21	21	21	21	21	21	21	21	21	21	21	21	21	7														
Landbank																																	
Estação Rio	2.885	jun-25		31	31	31	31	31	31	31	31	31	31	31	31	28																	
Mirante Boa Vista	**5.322**	**ago-25**				**25**	**25**	**25**	**25**	**25**	**25**	**25**	**25**	**25**	**25**	**25**	**25**	**25**	**25**	**25**	**25**	**25**	**17**										
Carolina Machado (Elevato Madureira)	3.894	dez-25								25	25	25	25	25	25	25	25	25	25	25	25	25	25	25	25	6							
Elevato Ramos	3.563	jun-26														28	28	28	28	28	28	28	28	28	28	28	28	28	28	28	28	28	18
Elevato Brasil	**3.598**	**jul-26**															**27**	**27**	**27**	**27**	**27**	**27**	**27**	**27**	**27**	**27**	**27**	**27**	**27**	**27**	**27**	**27**	**27**
Silva Vale I	**3.298**	**set-26**																	**27**	**27**	**27**	**27**	**27**	**27**	**27**	**27**	**27**	**27**	**27**	**27**	**27**	**27**	**27**
Luiza Vale	**3.499**	**fev-27**																						**23**	**23**	**23**	**23**	**23**	**23**	**23**	**23**	**23**	**23**
Silva Vale - II	**3.298**	**mar-28**																															
Silva Vale - Cond III	**3.298**	**set-29**																															
Silva Vale - Cond IV	**3.298**	**mar-31**																															
Total de Vendas Lançados			**21**	**21**	**21**	**21**	**21**	**21**	**21**	**21**	**21**	**21**	**21**	**21**	**21**	**21**	**21**	**21**	**7**														
Total de Vendas Lançados + Landbank			**21**	**52**	**52**	**77**	**77**	**77**	**77**	**102**	**102**	**102**	**102**	**102**	**102**	**127**	**99**	**99**	**112**	**105**	**105**	**105**	**97**	**103**	**103**	**84**	**78**	**78**	**78**	**78**	**78**	**78**	**68**
Vendas Produto Comitê						**25**	**25**	**25**	**25**	**25**	**25**	**25**	**25**	**25**	**25**	**25**	**25**	**25**	**52**	**52**	**52**	**52**	**44**	**50**	**50**	**50**	**50**	**50**	**50**	**50**	**50**	**50**	**50**
Total de Vendas Sem o Produto Comitê						**52**	**52**	**52**	**52**	**77**	**77**	**77**	**77**	**77**	**77**	**102**	**74**	**74**	**60**	**53**	**53**	**53**	**53**	**53**	**53**	**34**	**28**	**28**	**28**	**28**	**28**	**28**	**18**
Potencial Total da Mancha			**126**	**126**	**126**	**126**	**126**	**126**	**126**	**126**	**126**	**126**	**126**	**126**	**126**	**126**	**126**	**126**	**126**	**126**	**126**	**126**	**126**	**126**	**126**	**126**	**126**	**126**	**126**	**126**	**126**	**126**	**126**
Projetos Simultâneos na Mancha			**1**	**2**	**2**	**3**	**3**	**3**	**3**	**4**	**4**	**4**	**4**	**4**	**4**	**5**	**5**	**5**	**6**	**5**	**5**	**5**	**5**	**5**	**5**	**5**	**4**	**4**	**4**	**4**	**4**	**4**	**4**
Projetos Simultâneos na Mancha ex Coringas			**1**	**2**	**2**	**3**	**3**	**3**	**3**	**4**	**4**	**4**	**4**	**4**	**4**	**5**	**4**	**4**	**5**	**4**	**4**	**4**	**4**	**4**	**4**	**4**	**3**	**3**	**3**	**3**	**3**	**3**	**3**

One Page – Elevato Av.Brasil

[1]

Cidade	Rio de Janeiro	**Mancha de demanda**	RJ - RZN2 - Olaria + Ramos + Bonsucesso
Regional	RJ	**Cluster MPR**	3 - Verde
Cenário de Aprovação	Aprovação	**Tipo de Aprovação**	Consolidado
Fase Anterior			
Tipo de Comitê	Reversão s/ Reneg	**Versão da VF**	Versão 1.0: Jun

[2]

Unidades (% Vagas)	494 (0%)	**CA Máx | Proj**	7,0 | 4,0
Tipologia	F2E - Concreto	**Escritura**	mai-26
Fases	1 fases	**Lçto | Duração (m)**	jul/26 | 24

[3]

Valor Líquido do Terreno (% VGV)	10.111 (8,7%)	**Un. Perm. Fís (% Ter)**	0 (0,0%)
Cash (Correção)	1.550 (N/A)	**%VGV Perm Fin Líquida (% Ter)**	7,4% (84,7%)
Valor R$/m²	2.063	**VAR (%VGV)**	550 (0,5%)

[4]

Custo Construção (%VGV)	48.751 (42,1%)	**Indireto Unit.**	17.894
Prazo da Obra (meses)	18	**Torre Unit.**	58.470
Custo Total Unit. (LPU):	98.687 (91)	**Infra Unit.**	12.735
Início de Obra	jan-27	**Fundação Unit.**	6.257

[5]

Preço Nominal Unit.	234.192	**VSO**	27
Preço Raso Unit.	209.483	**Referência**	Vision
Avaliação Unit.	240.000	**Renda (% em RET 1%)**	3.598 (25,0%)

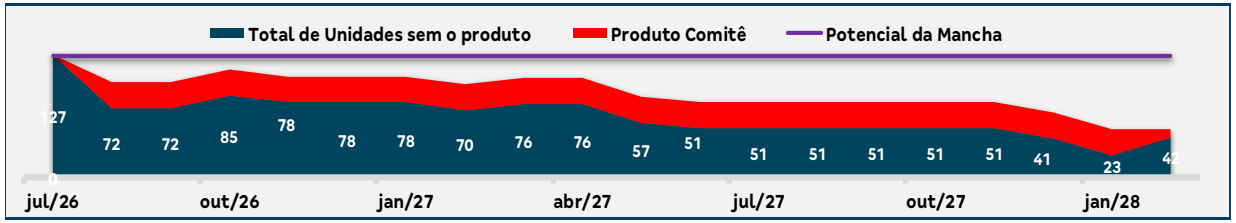

LI (Régua):	**20,2% (20,0%)**	**Margem Bruta Econômica:**	40,2%
LI Resiliência:	13,1% (N/A)	**Margem Rasa Econômica:**	32,4%
Margem Bruta REF:	43,3%	**Margem Contribuição Econômica**	28,5%
Margem Rasa REF:	**36,6%**	**Exposição (% VGV):**	15.647 (12,8%)
TIR:	99,7%	**VGV Total:**	115.691
Payback Contingente (21 m) :	**19 m/ (-2 m)**	**Ger. Caixa 12 meses (R$):**	(2.841)
Payback Consolidado:	19	**Ger. Caixa 24 meses (R$):**	(13.453)

Destaques

[1] Imóvel localizado na Zona Norte, no bairro de Ramos, divisa com os bairros de Bonsucesso, Olaria e Penha, com frentes para a Av.Brasil e Av. Postal. Entorno com farto transporte público, Corredor BRT Transcarioca / ônibus na Av. Brasil. Supermercados (Rede Economia, Vianense, Mundial e Guanabara), escolas e universidades (Municipal Clotilde Guimarães e Unisuam), Hospitais (Hospital Federal de Bonsucesso e Balbino), comércios (a 1,2km Centro de Bonsucesso e a 2,5km do Centro de Olaria) e serviços em geral.

[2] Implantação de Tipologia Vertical com 1 torre em L 16PP T+16 e 1 torre 14PP T+16. CA projetado = 3,95 com 494 unidades. **Estamos trazendo a comitê de reversão pois atingimos os parâmetros financeiros, com a redução de custos, para contabilizar 100% das unidades da meta.**

[3] Valor do terreno: R$ 10,5 milhões, sendo R$ 1,550 milhões em cash, com R$ 550 mil (0,48% do VGV) depositados em conta Escrow com A.F do terreno como garantia + R$ 1,0 milhão na ECV desde que superadas resolutivas, e saldo no valor de R$ 8,95 MM, em permuta financeira representada 7,4% do VGV total com valor mínimo garantido de R$ 8,95 MM (apuração 6 meses pós habite-se). Na VF: R$ 8,56MM em permuta financeira correspondendo a 7,40% líquido do VGV totalizando R$ 10,11MM.

[4]. Custo de torre vertical abaixo de R$ 99 mil com trabalho em conjunto entre prospecção e GETEC.

[5] Projeto inserido na faixa 2, com preço de venda e renda extremamente compatíveis, principalmente se comparados com a concorrência na região (slide 24)

- Pareceres
- Análise da Mancha e Implantação
- Prospecção
- Operações
- Inteligência de Mercado
- Financeiro

Farol Pareceres – Elevato Av. Brasil

Área	Riscos Associados	Parecer	Criticidade
Jurídico Imobiliário	Contrato de permuta financeira, com torna, assinado em 29/11/2024 e aditivo assinado em 10/03/2025 . **Due Diligence concluída em 02/2025 com os seguintes pontosde atenção:** **-Desapropriação**: Identificado o Decreto Municipal nº 45.656, de 7 de fevereiro de 2019, que determinou a desapropriação total do imóvel (e diversos outros) por interesse social para implementação do Plano Maré 2020, contudo conseguimos obter manifestação da PGM informando a caducidade (transcorridos mais de cinco anos desde a publicação do decreto e sem a efetiva desapropriação) e desinteresse em relação à desapropriação prevista no referido decreto. **- Gravames:** O imóvel encontra-se gravado com três penhoras em razão de processos trabalhistas, além de prenotações, que deverão ser baixados em até 6 meses da assinatura da PCV, com possibilidade de prorrogação por mais 6 meses, a critério da Tenda. **- Pagamento do sinal:** Foi previsto o pagamento de sinal de R$ 550.000,00 a ser depositado em conta Escrow de titularidade da Tenda, em até 120 dias após a assinatura do contrato, desde que superadas cumulativamente as seguintes condições: i) a conclusão positiva dos estudos técnicos preliminares a serem no imóvel; ii) a aprovação em comitê; iii) a conclusão positiva da Due Diligence inicial; Dada a existência de gravames na matrícula do imóvel, o valor depositado em Escrow só será liberado ao Vendedor após após a baixa dos gravames e assinatura da AF em favor da Tenda com o imóvel em garantia. **- Passivo e Ativo Sócios:** Foi constatado passivo de aproximadamente R$ 38 milhões em nome da Vendedora, cujo patrimônio se encontra comprometido. Como forma de mitigar os riscos, as empresas dos sócios foram incluídas no negócio como garantidoras das obrigações da Vendedora, por meio de aditivo contratual já assinado. Essas empresas apresentaram patrimônio superior a R$ 70 milhões, conferindo maior segurança quanto ao cumprimento das obrigações e à cobertura de eventuais contingências. Além disso, será prevista na escritura a possibilidade de a Tenda reter o pagamento do preço caso eventuais contingências venham a atingir o imóvel e usar o valor retido para adimplir as obrigações. **Resolutivas:** O contrato possui cláusula resolutiva master de saída (viabilidade técnica, financeira, comercial e jurídica).	Ok com ressalvas	
Legalização	Constam penhoras na matrícula. Serão necessárias as baixas para a conclusão do licenciamento. Necessária procuração em nome dos proprietários do terreno para tramitação dos processos. O Decreto 45656/2019 prevê a desapropriação total do terreno em razão do Plano Maré 2020 e não foi encontrada manifestação da prefeitura acerca de sua caducidade. A caducidade deverá ser comprovada para permitir o licenciamento. O viaduto adjascente ao terreno gerará uma FNA que será validada por meio de um processo de consulta já aberto na prefeitura. A construção do viaduto afetou parcialmente o terreno, o que demandará aprovação de novo PAA para a Avenida Postal e implicará a necessidade de doação de área de recuo e redução das metragens do terreno. O projeto já prevê esta futura redução de área e estima-se que não haverá perda de unidades. O empreendimento recebeu enquadramento nível 1 para bens arqueológicos. Há previsão de impacto para bens materiais e foi exigida a elaboração de uma RAIPM. Os custos estão previstos no orçamento. O terreno foi considerado como área contaminada sob investigação, segundo o relatório ambiental confirmatório. É necessária a execução de uma investigação detalhada para delimitar a pluma de contaminação proveniente da água subterrânea e para avaliar o risco à saúde humana. Os consultores avaliam que não haverá risco à saúde humana, porém deverá ser restringida a ingestão da água subterrânea. Custos previstos no orçamento.	Ok com ressalvas	
IMPLANTAÇÃO	Redução da área do terreno devido à FNA para manutenção do viaduto, impactando o Produto (áreas de lazer e estacionamento).	Ok com ressalvas	
GETEC	Laudo acústico emitido com cenário diferente do atual. O laudo informa a necessidade de caixilhos classe III (30dB) e caixilhos classe especial (>37dB). Os caixilhos foram estimados baseado no laudo emitido, sendo necessário a revisão do Custo após a emissão do laudo para o cenário atual. Laudo ambiental indica solo contamido, sendo necessário uma investigação detalhada conforme orientação do laudo. Não considerado nenhuma custo para remediação e/ou obras civis referente a contaminação, quaisquer custo ficaram a cargo de prospecção. Extensão de água considerado conforme envio da regional.	Ok com ressalvas	
Logística	Sem riscos associados.	Ok	
Inteligência de mercado	IM avalia o preço como factível.	Ok	
Comercial/Ciclo	CICLO avalia o Preço Vision como factível	Ok	
Estudos Econômicos	Sem riscos associados.	Ok	

Pareceres

Análise da Mancha e Implantação

Prospecção

Operações

Inteligência de Mercado

Financeiro

Mancha de Demanda

MANCHAS DE DEMANDA

- RZN – Rio de Janeiro Norte

Lançamento

1. Pátio Engenheiro Novo
2. Elevato Bonsucesso

LandBank

3. Estação Brasil
4. Estação Rio (Forja Rio)
5. Elevato Madureira
6. Oi São Cristóvão (Mirante Boa Vista)
7. Elevato Ramos
8. Elevato Av. Brasil
9. Silva Vale
10. Luiza Vale

Cluster MPR

- Cluster 3 - Verde

Região

Capital

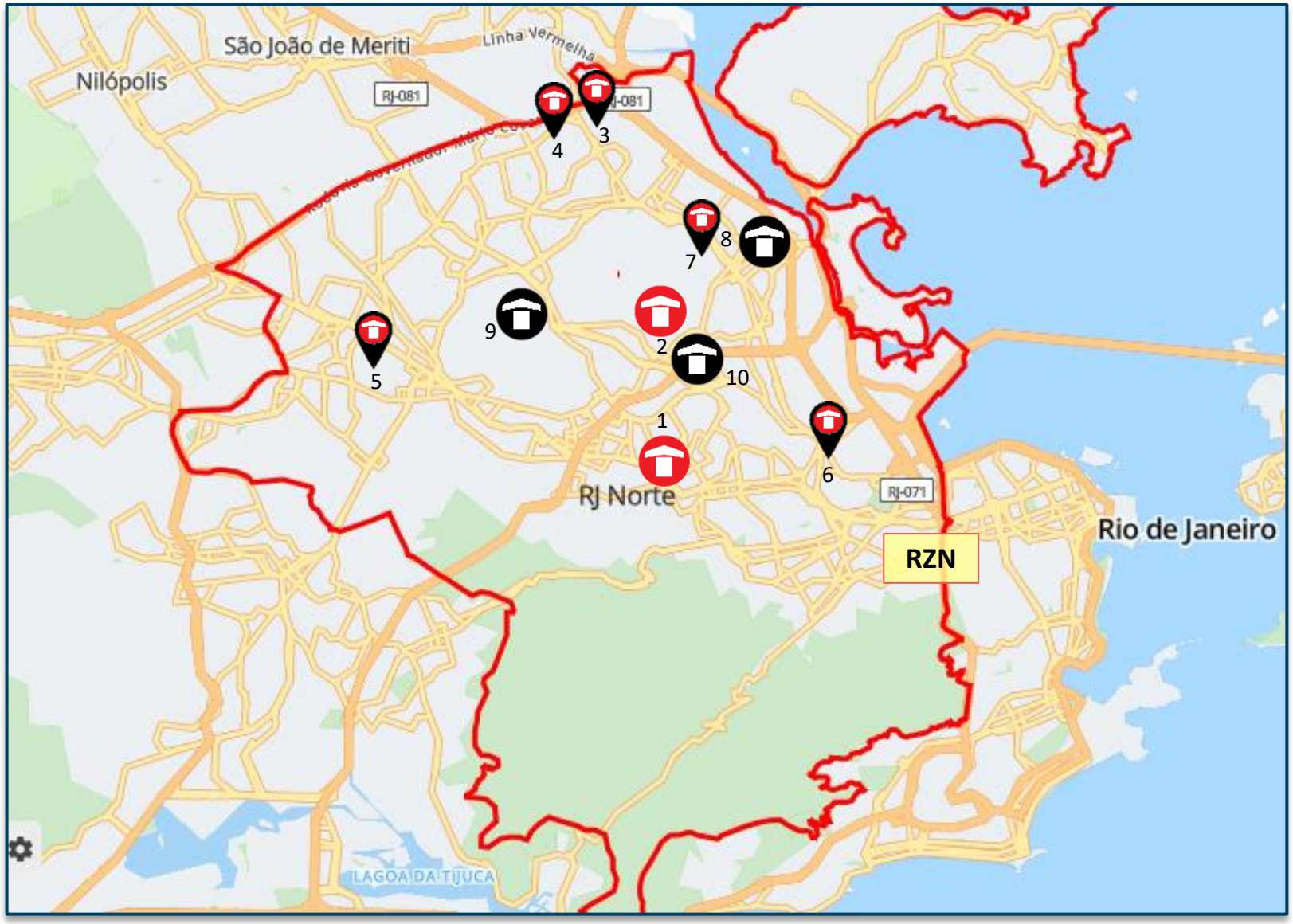

Lançados *LandBank* *Comitê*

Pareceres

Análise da Mancha e Implantação

Prospecção

Operações

Inteligência de Mercado

Financeiro

Macrolocalização

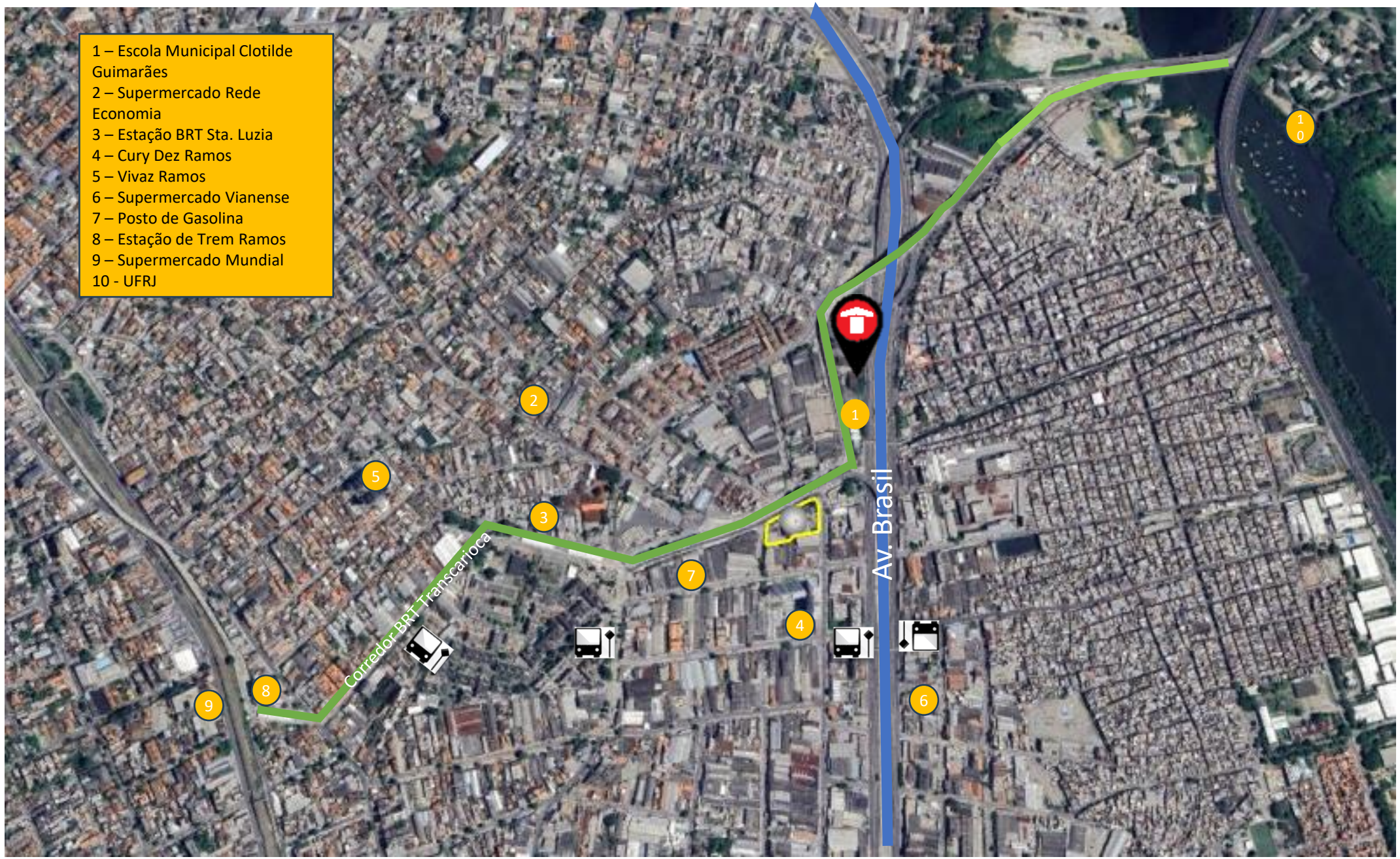

PRODUTO

Empreendimento Elevato Avenida Brasil (Av. Postal)
Investimento

Informações Gerais – Condomínio Único		
Terreno	Área terreno	5.909,41m²
	Menor poligonal	5.486,82m²
	FNA	Sim - 5m
	Reserva de calçada/ melhoramento víario	Não
	Área liquida	5.371,52m²
	Zoneamento	ZFU
	Ca básico | máximo	1 | 7
	Ca projetado	3,95
	Gabarito máximo	T+21(LEG) | T+16 (COMAER)
Geral	Total uh	494
	Total de vagas	06
Tipologia	Tipologia	Modular com elevador
	Gabarito	T+15 e T+16
	Lâmina	14PP | 16PP
	Área privativa	34,04m²
Condomínio	Unidade pcd	15
	Unidade lazer | técnica	0 | 2
	Torre	02
	Fase	única
Lazer	Lazer coberto	Salão de Festas, Churrasqueira, Brinquedoteca
	Lazer descoberto	Playground, Quadra, Fitness

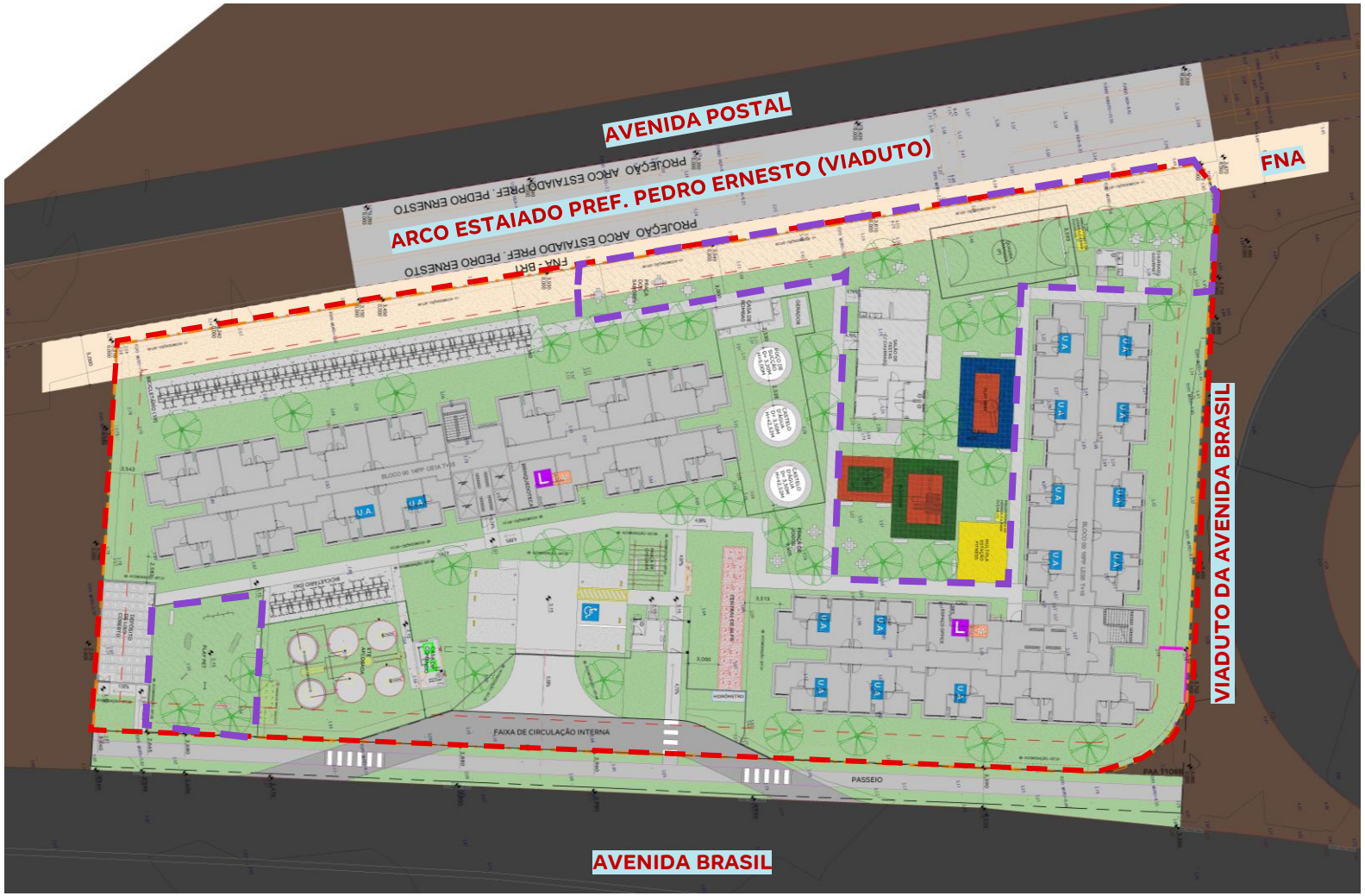

ÁREAS DE LAZER

PRODUTO

Empreendimento Elevato Avenida Brasil (Av. Postal)
Investimento

	Descrição	Criticidade	Parecer
Usabilidade	**Limite supercondomínio**		
	Acesso		
	Percurso do pedestre até torre		
Diferencial produto	**Atributos Infra**	Sim	Mini Mercado
	Atributos Torre	Não	
	Edifício Garagem	Não	

Perspectiva

Condições do Negócio

➢ VALOR DO NEGÓCIO – R$ 10.500.000,00

- R$ 550.000,00 em cash em até 120 dias (mar/25) após assinatura da PCV, a ser depositado em conta Escrow de titularidade da Tenda, desde que superadas cumulativamente as seguintes condições:
  i) a conclusão positiva dos estudos técnicos preliminares a serem no imóvel;
  ii) a aprovação em comitê;
  iii) a conclusão positiva da Due Diligence inicial;
  Dada a existência de gravames na matrícula do imóvel, o valor depositado em Escrow só será liberado ao Vendedor após a baixa dos gravames e assinatura da AF em favor da Tenda com o imóvel em garantia. Caso a Tenda venha a rescindir o contrato, a seu exclusivo critério de forma injustificada mesmo que superadas todas as clausulas resolutivas (inclusive a Master que possui aprovação em comitê), a Vendedora poderá reter o valor de sinal R$ 550.000,00, caso assim já o tenha recebido.

- R$ 1.000.000,00 em cash na ECV desde que superadas as resolutivas;

- Na minuta: R$ 8.950.000,00 em permuta financeira correspondendo a 7,4% líquido do VGV total. Valor Mínimo Garantido.
- NA VF: R$ 8.561.148,00 em permuta financeira correspondendo a 7,4% líquido do VGV total. Valor Mínimo Garantido de R$ 8.950.000,00. (o percentual de permuta permanece os 7,4% do contrato, que será repassado mensalmente, porém será necessário complementar ao final para atingir o mínimo, pois houve redução do preço de venda após o fechamento da negociação).

- Caso o Valor Mínimo Garantido não seja alcançado em até 6 meses após expedição do Habite-se, deveremos quitar a diferença em até 30 dias em parcela única. Caso o valor já tenha sido atingido ou superado , a obrigação será considerada quitada. Atualmente na VF deveríamos quitar R$ 854.320,00 nesse momento.

➢ CORREÇÃO MONETÁRIA

- N/A.

Condições do Negócio

➢ **PRAZOS CONTRATUAIS**

- PCV assinada em 29 de novembro de 2024.
- Aditivo assinado 10 de março de 2025.
- Prazo para aprovação do projeto e superação das resolutivas de 12 + 6 meses, quando assinaremos a ECV.

- **CONDIÇÕES RESOLUTIVAS**
- Presença de todas resolutivas padrão Tenda.

➢ **GARANTIAS**

- Para Vendedores: aval Construtora Tenda
- Para Tenda: AF sobre o imóvel garantindo devolução do sinal.

➢ **CORRETAGEM**

- Corretagem 5% sobre o valor do negócio pagos 60% para a Agrega Desenvolvimento Imobiliário Ltda e 40% para Makkil.

Pareceres

Análise da Mancha e Implantação

Prospecção

Operações

Inteligência de Mercado

Financeiro

Custo de Construção

	ELEVATO AV.BRASIL CEN02 | REV03	ELEVATO AV. BRASIL CEN02 | REV02
Torres	2	2
Unidades Construídas	496	496
Unidades Vendidas	494	494
Total Unidades Vendidas	494	494
Condomínios (qta.)	1	1
Cidade	Rio de Janeiro - RJ	Rio de Janeiro - RJ
Produto / Selo	F2E MODULAR	F2E MODULAR
Tipologia	1 Torre | T+15 | 14PP LN | CE1A	1 Torre | T+15 | 14PP LN | CE1A
Tipologia	1 Torre | T+16 | 16PP LN | LE3B	1 Torre | T+16 | 16PP LN | LE3B
Tipologia	-	-
Atributos	Quadra	Quadra
Projeto Infra	AP	AP
Projeto Torre	AP	AP
Mês Base	junho-25	maio-25
Incc	1.184,462	1.178,386
LVS	abril-25	março-25
Indiretos	abril-25	março-25
Base de Preço	LPU 91	LPU 89
Takt	2+2	2+2
Prazo (mês)	18	18
CUSTO TOTAL I	R$ / UND R$ 97.158	R$ / UND R$ 98.953
Indireto	R$ 17.894	R$ 18.410
Torre	R$ 58.470	R$ 58.728
Infra	R$ 12.735	R$ 13.922
Fundação	R$ 6.257	R$ 6.097
EEE	R$ 247	R$ 247
ETE	R$ 1.012	R$ 1.012
Contenção	R$ 74	R$ 68
Terraplenagem	R$ 469	R$ 469
CUSTO TOTAL II	R$ 1.529	R$ 1.528
Urbanização	R$ 667	R$ 666
Drenagem	R$ 91	R$ 91
Extensão de Rede Elétrica		
Extensão de Rede Hidráulica	R$ 770	R$ 770
CUSTO TOTAL III		
Incorridos		
CUSTO TOTAL IV		
Aprendizado		
CUSTO TOTAL V		R$ 518
Atualização por INCC		R$ 518
CUSTO TOTAL I+II	R$ 98.687	R$ 100.480
CUSTO TOTAL I AO IV	R$ 98.687	R$ 100.998

Custo de Construção

	ELEVATO AV.BRASIL CEN02 | REV03	ELEVATO AV. BRASIL CEN02 | REV02	
Torres	2	2	
Unidades Construídas	496	496	
Unidades Vendidas	494	494	
Condomínios (qta.)	1	1	
Cidade	Rio de Janeiro - RJ	Rio de Janeiro - RJ	
Produto / Selo	F2E MODULAR	F2E MODULAR	
Tipologia	1 Torre | T+15 | 14PP LN | CE1A	1 Torre | T+15 | 14PP LN | CE1A	
Tipologia	1 Torre | T+16 | 16PP LN | LE3B	1 Torre | T+16 | 16PP LN | LE3B	
Atributos	Quadra	Quadra	
Projeto Infra	AP	AP	
Projeto Torre	AP	AP	
Mês Base	junho-25	maio-25	
Incc	1184,462	1178,386	
LVS	abril-25	março-25	
Indiretos	abril-25	março-25	
Base de Preço	LPU 91	LPU 89	
Takt	2+2	2+2	
Prazo (mês)	18	18	
CUSTO TOTAL I	R$ / UND R$ 97.158	R$ / UND R$ 98.953	DIF -R$ 1.794
Indireto	R$ 17.894	R$ 18.410	-R$ 516
Torre	R$ 58.470	R$ 58.728	-R$ 258
Infra	R$ 12.735	R$ 13.922	-R$ 1.187
Fundação	R$ 6.257	R$ 6.097	R$ 159
EEE	R$ 247	R$ 247	R$ 0
ETE	R$ 1.012	R$ 1.012	R$ 0
Contenção	R$ 74	R$ 68	R$ 7
Terrapplenagem	R$ 469	R$ 469	R$ 0
CUSTO TOTAL II	R$ 1.529	R$ 1.528	R$ 1
Urbanização	R$ 667	R$ 666	R$ 1
Drenagem	R$ 91	R$ 91	R$ 0
Extensão de Rede Eletrica	R$ 0	R$ 0	R$ 0
Extensão de Rede Hidráulica	R$ 770	R$ 770	R$ 0
CUSTO TOTAL III	R$ 0	R$ 0	R$ 0
Incorridos	R$ 0	R$ 0	R$ 0
CUSTO TOTAL IV	R$ 0	R$ 0	R$ 0
Aprendizado	R$ 0	R$ 0	R$ 0
CUSTO TOTAL V	R$ 0	R$ 518	-R$ 518
Atualização por INCC	R$ 0	R$ 518	-R$ 518
CUSTO TOTAL	R$ 98.687	R$ 100.998	-R$ 2.311

INDIRETOS

-604 | G16 – Equipamentos – Preço SLQA e consideração de reaproveitamento entre obras

TORRE

-208 | Elevador – Elevador 14PP conforme contratação Elevato Bonsucesso

INFRA

-1.077 | Reservatório Metálico – Conforme input interno

R03: 2 Reservatórios Ø 3,50m – 34,83m - 14.523 kg/castelo

R02: 2 Reservatórios Ø 3,50m – 42,52m - 26.344 kg/ castelo

Operações

SISTEMA DE ABASTECIMENTO DE ÁGUA
Sem viabilidade técnica emitida. Considerando 350 m de extensão de rede DN150MM , conforme solicitado pelo regional, por Email.

SISTEMA DE ESGOTAMENTO SANITÁRIO
Sem viabilidade técnica emitida. Custo considera ETE e emissário da ETE no mesmo da drenagem.

SISTEMA DE DRENAGEM
Conforme relatório técnico emitido pela WH Consultoria e Projetos, considera 11 m de rede de drenagem para a ligação na Av. Brasil.

SISTEMA DE ABASTECIMENTO DE GÁS
Abastecimento por GLP.

SISTEMA DE ABASTECIMENTO ELÉTRICO
Sem viabilidade técnica emitida.

TERRENO

URBANIZAÇÃO
Considerando execução da pista do viário de acesso e calçadas do entorno do empreendimento.

Operações

Matriz Risco Concessionária	
Água	Nível 3
Esgoto	Nível 3
Drenagem	Nível 3
Elétrica	Nível 5
Gás	NA
Urbanização	Nível 5

LEGENDA		
Nível	Tipo	Status
1	Com Diretriz	Conclusiva
2		Conclusiva com projeto aprovado
3		Conclusiva sem projeto aprovado
4		Não Conclusiva
5	Sem Diretriz	-
NA	-	Não aplicável

Água:
- Viabilidade emitida 12/24, com vencimento 12/26. Consideração conforme e-mail da Regional.

Esgoto:
- Viabilidade emitida 12/24, com vencimento 12/26

Drenagem:
- Não há viabilidade.

Elétrica:
- Viabilidade ainda não foi emitida.

Gás:
- Não se aplica. Empreendimento com GLP.

Urbanização:
- Considerado a execução da pista do viário de acesso e o passeio da testada do empreendimento.

Fundação:
- Realizada campanha de sondagem contemplando 7 furos.
- Considerada Estaca Hélice Contínua, com diâmetros de Ø40 cm, Ø50 cm e Ø60 cm e profundidade média de 12 m a 14m

Logística

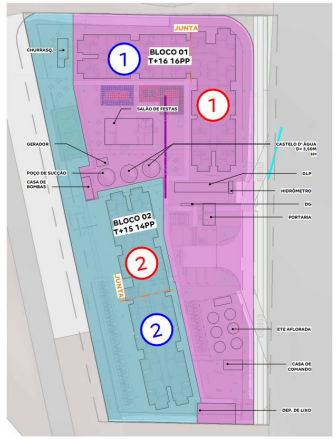

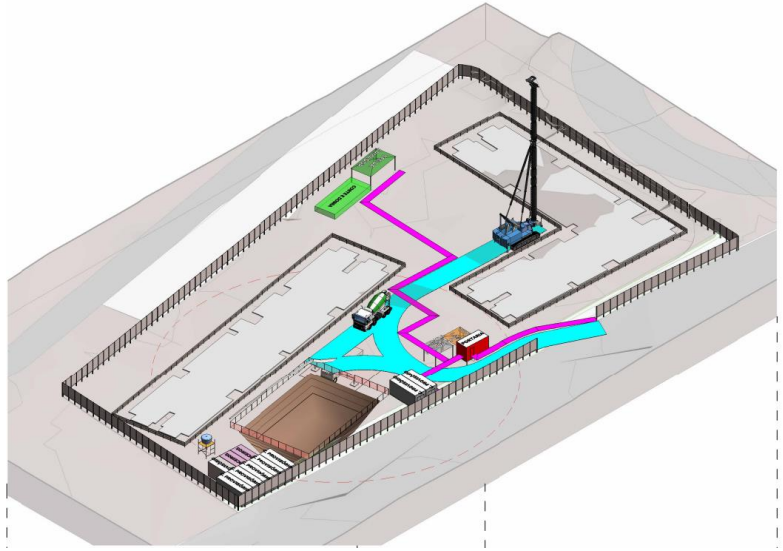

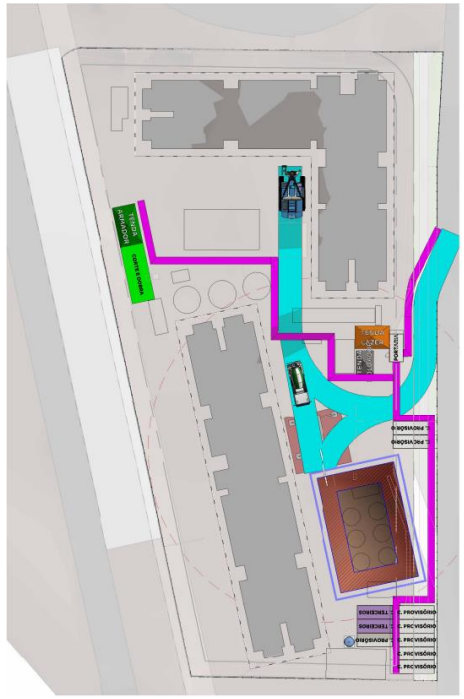

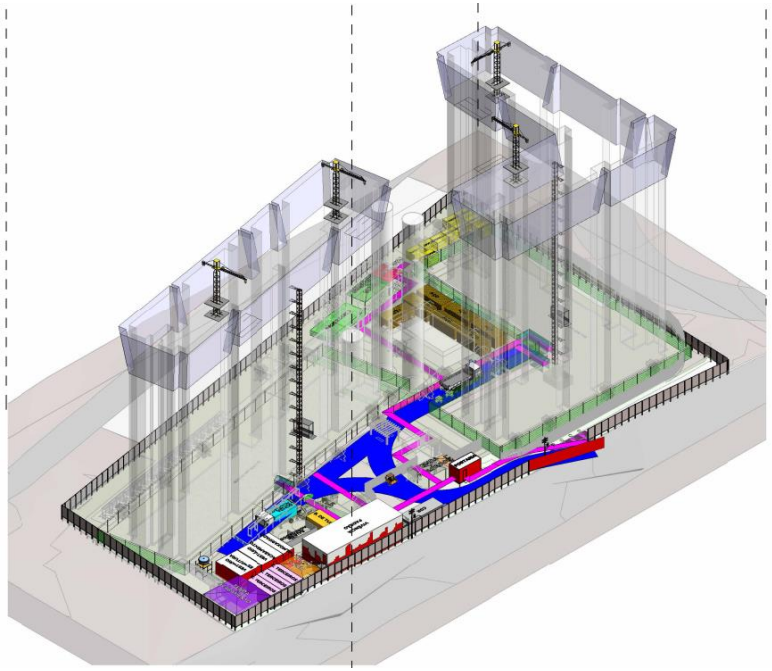

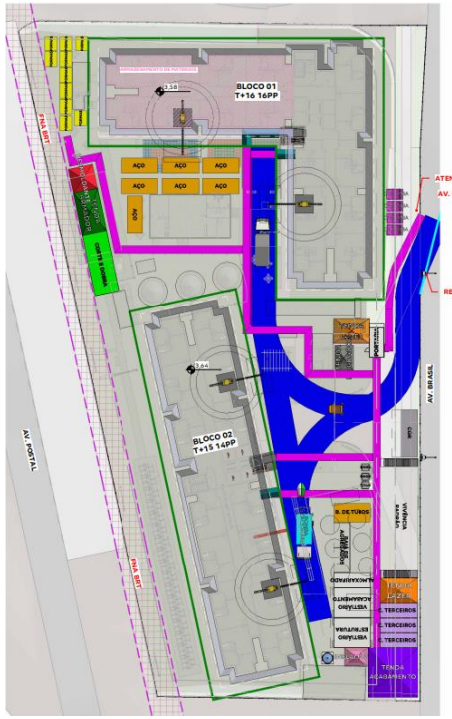

VIVÊNCIA - CONTAINERS									
DESCRIÇÃO	QUANTIDADE	TAMANHO MÓDULOS	MOBILIZAÇÃO	DESMOBILIZAÇÃO	PRÉ FORMA	ESTRUTURA	ACAB.	FASE	CÓDIGO ORÇAMENTO
CONTAINER ALMOXARIFADO (LOG)	1 MÓDULO DE CONTAINER	2,41 X 6,10 m	1 MOBILIZAÇÃO	1 DESMOBILIZAÇÃO	-	TODO PERÍODO	TODO PERÍODO	UNICA	
CONTAINER PORTARIA (LOG)	CONSIDERAR 1 MÓDULO COM SANITÁRIO E CATRACA	2,41 X 4,90 m	1 MOBILIZAÇÃO	1 DESMOBILIZAÇÃO	TODO PERÍODO	DEFINITIVA	DEFINITIVA	UNICA	
CONTAINER PROVISÓRIO (LOG)	CONSIDERAR 8 MÓDULOS DE CONTAINER	2,41 X 6,10 m	1 MOBILIZAÇÃO	1 DESMOBILIZAÇÃO	TODO PERÍODO	-	-	UNICA	
CONTAINER VESTIÁRIO ACABAMENTO (LOG)	CONSIDERAR 2 MÓDULOS DE CONTAINER	2,41 X 6,10 m	1 MOBILIZAÇÃO	1 DESMOBILIZAÇÃO	-	-	TODO PERÍODO	UNICA	
CONTAINER VESTIÁRIO ESTRUTURA (LOG)	CONSIDERAR 2 MÓDULOS DE CONTAINER (EQUIPE VERTICAL)	2,41 X 6,10 m	1 MOBILIZAÇÃO	1 DESMOBILIZAÇÃO	-	TODO PERÍODO	-	UNICA	
CONTAINER VIVÊNCIA PADRÃO (LOG)	CONSIDERAR 14 MÓDULOS COM 2 ESCADAS (7 MÓDULOS NO PAV. T E 7 MÓDULOS NO PAV SUPERIOR)	2,41 X 6,10 m	1 MOBILIZAÇÃO	1 DESMOBILIZAÇÃO	-	TODO PERÍODO	TODO PERÍODO	UNICA	

TENDAS_PERÍODOS								
DESCRIÇÃO	QUANTIDADE	LARGURA	COMPRIMENTO	PRÉ FORMA	ESTRUTURA	ACABAMENTO	FASE	CÓDIGO ORÇAMENTO
GAIOLA DE DESMOLDANTE (LOG)	1	4,00	4,00	-	TODO PERÍODO	-	UNICA	
GAIOLA DE INFLAMÁVEIS (LOG)	1	3,00	4,00	-	TODO PERÍODO	TODO PERÍODO	UNICA	
TENDA ACABAMENTO (LOG)	1	8,00	8,00	-	TODO PERÍODO	TODO PERÍODO	UNICA	
TENDA ARMADOR (LOG)	1	4,00	7,00	TODO PERÍODO	TODO PERÍODO	-	UNICA	
TENDA LAZER (LOG)	2	4,00	6,00	-	TODO PERÍODO	TODO PERÍODO	UNICA	
TENDA MOLDADOR (LOG)	1	3,00	4,00	TODO PERÍODO	TODO PERÍODO	-	UNICA	

EQUIPAMENTOS E MAQUINÁRIOS								
EQUIPAMENTO	QUANTIDADE	MOBILIZAÇÃO	DESMOBILIZAÇÃO	PRÉ FORMA	ESTRUTURA	ACABAMENTO	FASE	CÓDIGO ORÇAMENTO
BETONEIRA (LOG)	VARIÁVEL	-	-	TODO PERÍODO	TODO PERÍODO	-	UNICA	
BOBCAT (LOG)	1 EQUIPAMENTO	1 MOBILIZAÇÃO	1 DESMOBILIZAÇÃO	-	TODO PERÍODO	CONSIDERAR 15 DIAS DO PERÍODO DE ACABAMENTO	UNICA	
BOMBA ESTACIONÁRIA PADRÃO (LOG)_R01	1 EQUIPAMENTO	-	-	-	TODO PERÍODO	-	UNICA	
BOMBA LANÇA (LOG)	VARIÁVEL	-	-	TODO PERÍODO	TODO PERÍODO	-	UNICA	
CAMINHÃO MUNCK (LOG)	1 EQUIPAMENTO	1 MOBILIZAÇÃO	1 DESMOBILIZAÇÃO	-	CONSIDERAR MEIO PERÍODO DE ESTRUTURA	-	UNICA	
CREMALHEIRA PCT (LOG)	2 EQUIPAMENTOS	1 MOB POR TORRE	1 DESMOB POR TORRE	-	TODO PERÍODO	TODO PERIODO	UNICA	
MINIGRUA (LOG)	1 EQUIPAMENTO	1 MOB POR MINIGRUA POR TORRE (TAKT 2X2)	1 DESMOB POR MINIGRUA POR TORRE (TAKT 2X2)	-	TODO PERÍODO	-	UNICA	
PERFURATRIZ (LOG)	1 EQUIPAMENTO	1 MOBILIZAÇÃO	1 DESMOBILIZAÇÃO	CONSIDERAR PERÍODO DE ESTACA CONFORME PROJETO.	-	-	UNICA	

Logística

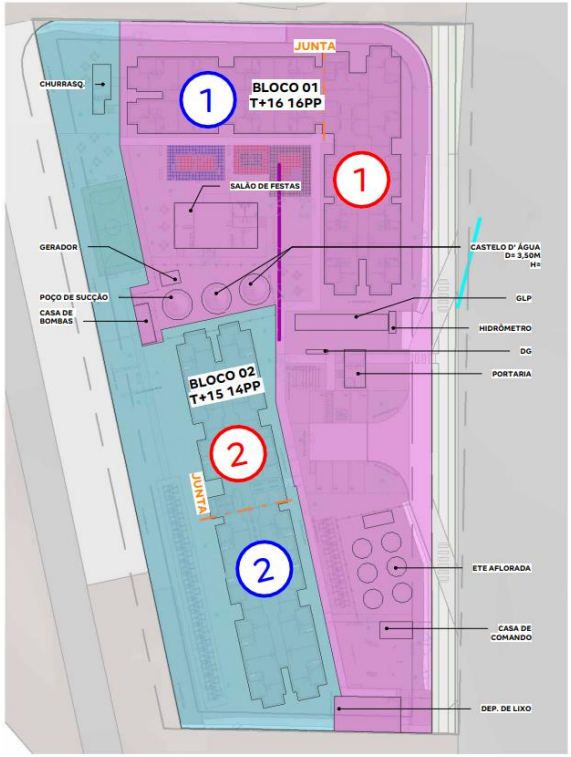

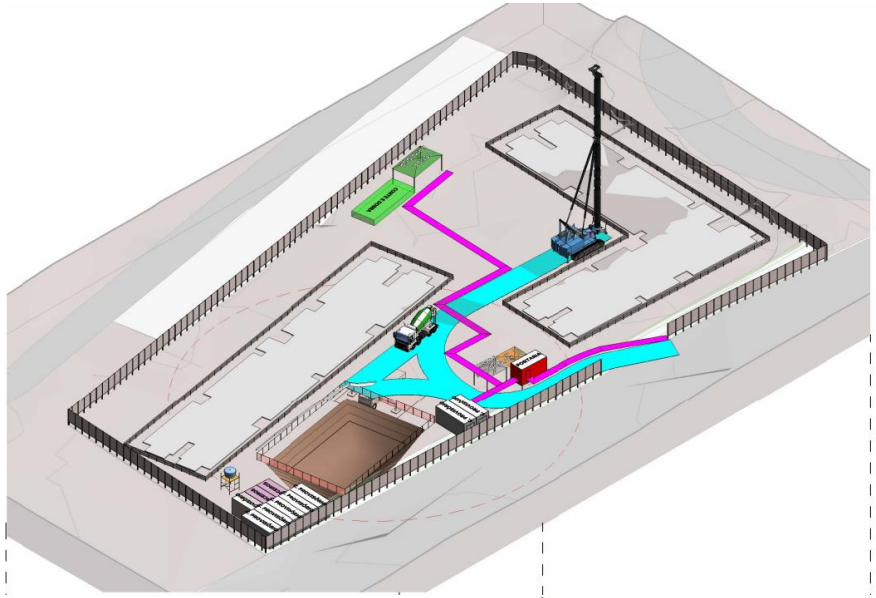

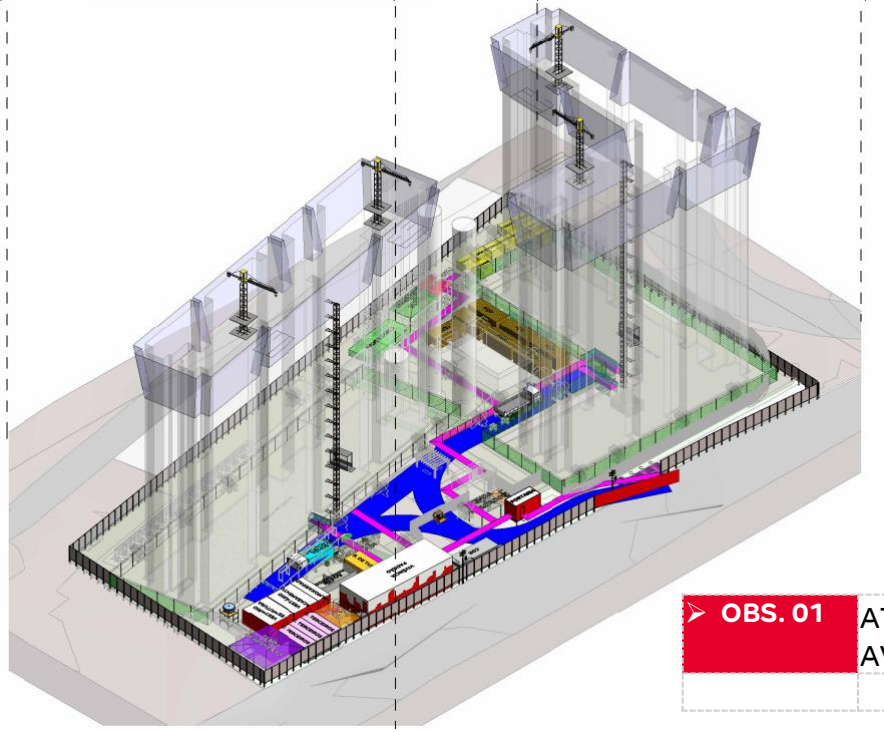

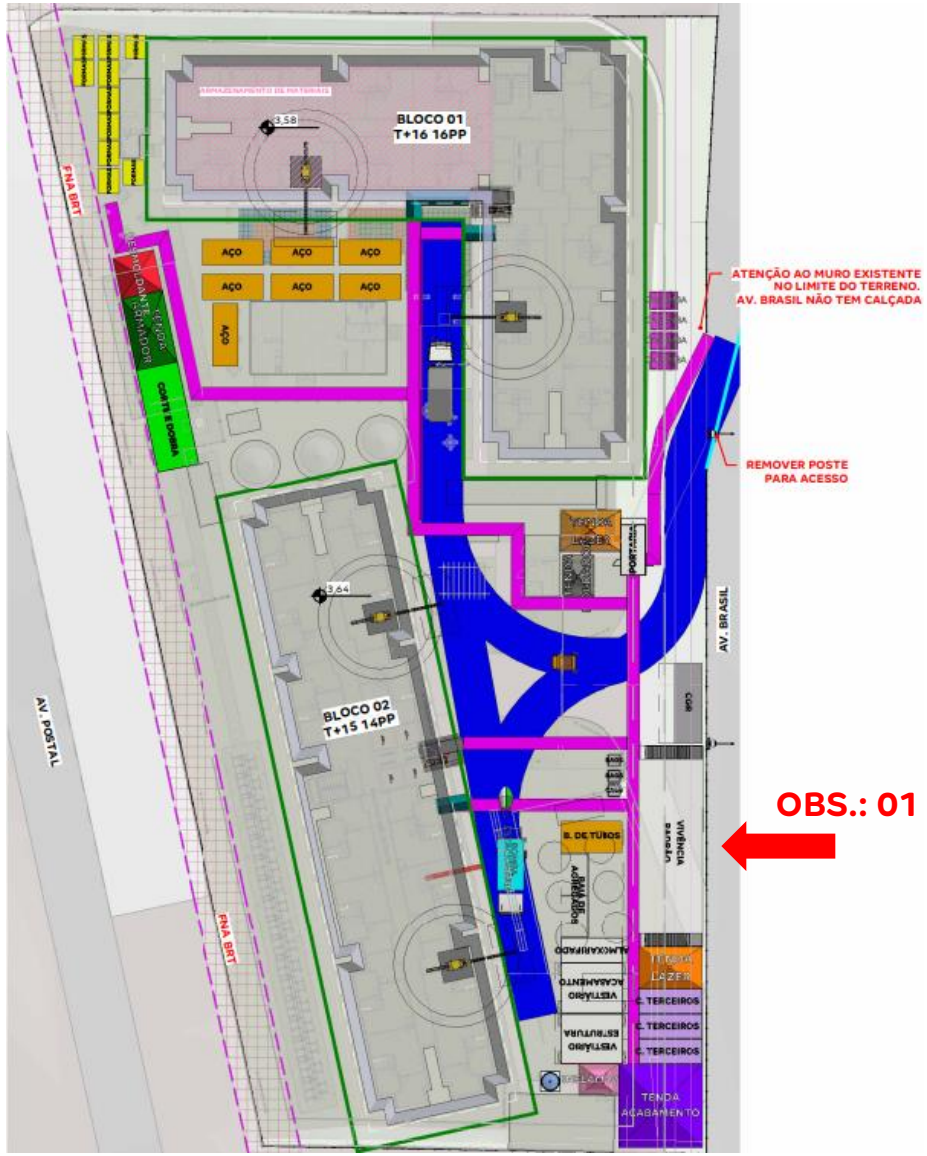

➢ OBS. 01	ATENÇÃO AO MURO EXISTENTE NO LIMITE DO TERRENO. AV. BRASIL NÃO TEM CALÇADA

Logística

ITENS A SEREM CONSIDERADOS:

CUSTOS / OBRA	ATENÇÃO EM RELAÇÃO À REDE ELÉTRICA PASSANDO NA TESTADA DO EMPREENDIMENTO. POSTE DEVERÁ SER REMOVIDO.

Pareceres

Análise da Mancha e Implantação

Prospecção

Operações

Inteligência de Mercado

Financeiro

Demanda e Distribuição da Mancha

Potencial de Demanda			Lançados		Lançados + Landbank	
Mancha	CÓD.	Shr.	ANO	MÊS	ANO	MÊS
Rio de Janeiro Norte	RZN	22%	1.259	105	1.511	126

Empreendimento	Renda	Lançamento	jun/25	jul/25	ago/25	set/25	out/25	nov/25	dez/25	jan/26	fev/26	mar/26	abr/26	mai/26	jun/26	jul/26	ago/26	set/26	out/26	nov/26	dez/26	jan/27	fev/27	mar/27	abr/27	mai/27	jun/27	jul/27	ago/27	set/27	out/27	nov/27	dez/27
Lançados																																	
Elevato Bonsucesso	3.444		21	21	21	21	21	21	21	21	21	21	21	21	21	21	21	21	7														
Landbank																																	
Estação Rio	2.885	jun-25		31	31	31	31	31	31	31	31	31	31	31	31	28																	
Mirante Boa Vista	**5.322**	**ago-25**				**25**	**25**	**25**	**25**	**25**	**25**	**25**	**25**	**25**	**25**	**25**	**25**	**25**	**25**	**25**	**25**	**25**	**17**										
Carolina Machado (Elevato Madureira)	3.894	dez-25								25	25	25	25	25	25	25	25	25	25	25	25	25	25	25	25	6							
Elevato Ramos	3.563	jun-26														28	28	28	28	28	28	28	28	28	28	28	28	28	28	28	28	28	18
Elevato Brasil	**3.598**	**jul-26**															**27**	**27**	**27**	**27**	**27**	**27**	**27**	**27**	**27**	**27**	**27**	**27**	**27**	**27**	**27**	**27**	**27**
Silva Vale I	**3.298**	**set-26**																	**27**	**27**	**27**	**27**	**27**	**27**	**27**	**27**	**27**	**27**	**27**	**27**	**27**	**27**	**27**
Luiza Vale	**3.499**	**fev-27**																						**23**	**23**	**23**	**23**	**23**	**23**	**23**	**23**	**23**	**23**
Silva Vale - II	**3.298**	**mar-28**																															
Silva Vale - Cond III	**3.298**	**set-29**																															
Silva Vale - Cond IV	**3.298**	**mar-31**																															
Total de Vendas Lançados			**21**	**21**	**21**	**21**	**21**	**21**	**21**	**21**	**21**	**21**	**21**	**21**	**21**	**21**	**21**	**21**	**7**														
Total de Vendas Lançados + Landbank			**21**	**52**	**52**	**77**	**77**	**77**	**77**	**102**	**102**	**102**	**102**	**102**	**102**	**127**	**99**	**99**	**112**	**105**	**105**	**105**	**97**	**103**	**103**	**84**	**78**	**78**	**78**	**78**	**78**	**78**	**68**
Vendas Produto Comitê						**25**	**25**	**25**	**25**	**25**	**25**	**25**	**25**	**25**	**25**	**25**	**25**	**25**	**52**	**52**	**52**	**52**	**44**	**50**	**50**	**50**	**50**	**50**	**50**	**50**	**50**	**50**	**50**
Total de Vendas Sem o Produto Comitê						**52**	**52**	**52**	**52**	**77**	**77**	**77**	**77**	**77**	**77**	**102**	**74**	**74**	**60**	**53**	**53**	**53**	**53**	**53**	**53**	**34**	**28**	**28**	**28**	**28**	**28**	**28**	**18**
Potencial Total da Mancha			**126**	**126**	**126**	**126**	**126**	**126**	**126**	**126**	**126**	**126**	**126**	**126**	**126**	**126**	**126**	**126**	**126**	**126**	**126**	**126**	**126**	**126**	**126**	**126**	**126**	**126**	**126**	**126**	**126**	**126**	**126**
Projetos Simultâneos na Mancha			**1**	**2**	**2**	**3**	**3**	**3**	**3**	**4**	**4**	**4**	**4**	**4**	**4**	**5**	**5**	**5**	**6**	**5**	**5**	**5**	**5**	**5**	**5**	**5**	**4**	**4**	**4**	**4**	**4**	**4**	**4**
Projetos Simultâneos na Mancha ex Coringas			**1**	**2**	**2**	**3**	**3**	**3**	**3**	**4**	**4**	**4**	**4**	**4**	**4**	**5**	**4**	**4**	**5**	**4**	**4**	**4**	**4**	**4**	**4**	**4**	**3**	**3**	**3**	**3**	**3**	**3**	**3**

No esgotamento acima não foi considerado na soma o projeto Elevato Brasil por se tratar de um projeto coringa.

Parecer de I.M sobre a mancha:

O projeto analisado em comitê está acima do potencial teórico de demanda calculado para a mancha. (Total Lanç + Landbank)

Canibalização:

Sem Risco de Canibalização

Concorrência

Elevato Brasil | Mapa Concorrência

		Elevato Brasil	Reserva Redentor - Fase 1
		TENDA	MRV
	Distância Tenda (km)		3,4km
Região 1 Km	População	65.276	30.397
	Dens. Demográfica	20.912	9.738
	Renda (R$)	4.191	5.203
	Classe Social	C1 (2.7k a 4.6k)	C1 (2.7K a 4.6K)
	PEA Dia	49.323	46.525
Quantitativo	Lançamento	nov/26	out/24
	Unidades	494	204
	Estoque	494	132
	VSO	27	22
	Stockout	18	6
Qualitativo	Condomínios	1	1
	Torres	3	1
	Gabarito	T+15	T+16
	Plantas (m²)	34m²	35,36m² e 36,56m² e 36,31m²
	Tipologia	2 Dorms	1 e 2 Dorms
	Opções	Não	Garden
	Varanda	Não	Não
	Suite	Não	Não
	Dif. Entrega	Não	Equipado e Decorado
	Vagas	0% de Vagas	100% Vagas
	Lazer	Salão De Festas, Playkid, Playpet, Playbaby, Multipla Estação Fitness, Quadra Gramada, Duchas	Tem Garden, Agua Aquecida a Gas, Bosque, Cinema, Fireplace, Lago, Piscina, Piscina Aquecida, Piso Elevado, Praça, Salão de Jogos,

Tipologias	Empreendimento	Tenda	Reserva Redentor	
	Tipologia	Sem Vaga	Sem Vaga	Garden
	Preço Nominal	234.193	260.990	296.990
	CEF	186.530	208.792	237.592
	Renda	3.598	4.225	5.075
	% Unidades	100%	88%	12%
	Dif Renda		627	-
	Farol de Factibilidade		●	●

Farol Renda
● Acima de 300
● Entre 0 e 300
● Abaixo de 0

Diagnóstico Concorrência

- A concorrência possui target de preço e renda acima ao previsto para o Elevato Brasil

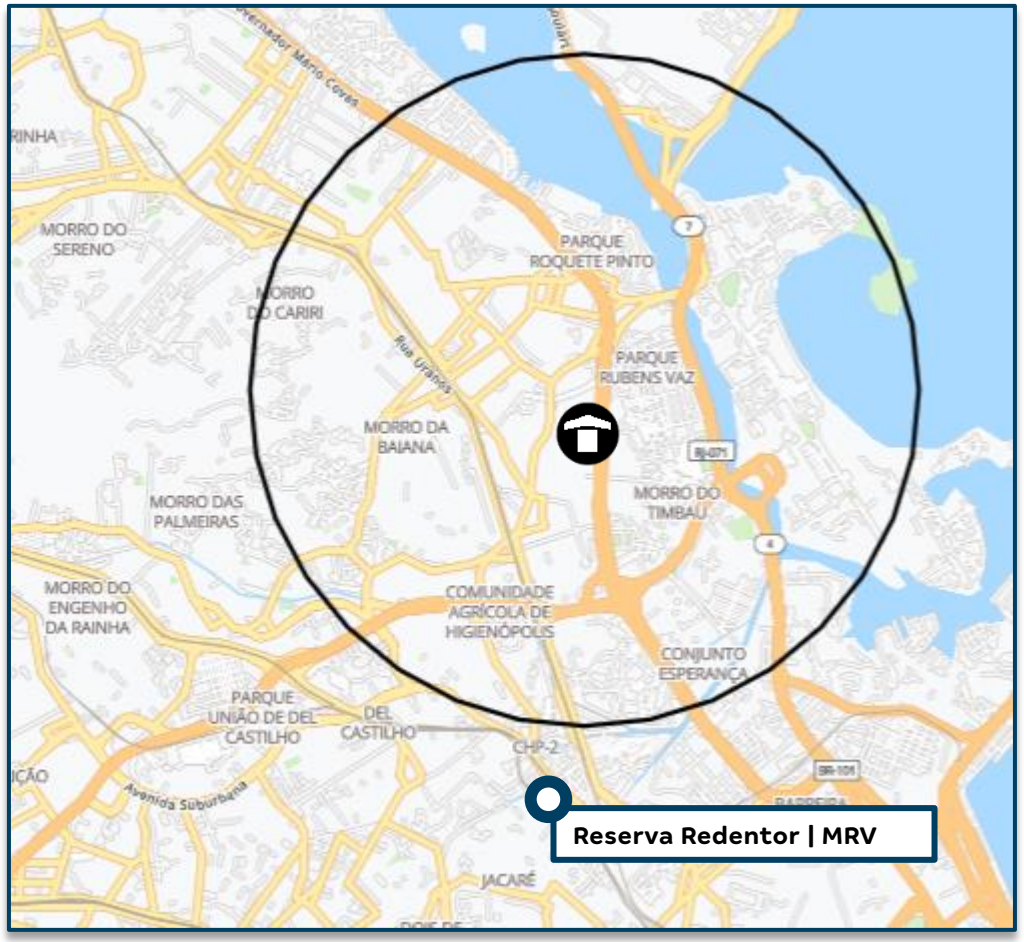

Precificação

Simulação de Preço

Informações Viabilidade

Projeto:	Elevato Brasil
Tipo:	**Faixa 2**
Método	**Vision**
Avaliação	240.000
Renda Inicial (VF)	3.598
Renda Final*	-
% RET1	25%

Tipo:	VF	R$
Ato	0,53	1.891
FGTS	0,52	1.856
Financiamento	94,58%	176.841
Subsídio	327,59%	7.833
Prazo de Pró-soluto	23	23
Pró-Soluto	70,12%	21.082
Preço Raso (RS)	209.503	209.503
TCD	68,07%	24.689
VSO	27	27
Preço de Venda	**237.357**	**237.357**
Elasticidade	-1,333%	-1,333%
Preço de Venda Final	**234.193**	**234.193**
Preço Raso (R$)	**209.503**	
% de Raso	**89,46%**	
BP25 - Não Inflacionado	**-**	
BP25 - Inflacionado	**-**	

Análise de Preço

Informações Viabilidade

Projeto:	Elevato Brasil
Tipo:	**Faixa 2**
Método	**Vision**
Avaliação	240.000
Renda Inicial (VF)	3.598
Renda Final*	-

Tipo:	VF	R$
Ato	0,53	1.891
FGTS	0,52	1.856
Financiamento	94,58%	176.841
Subsídio	327,59%	7.833
Prazo de Pró-soluto	23	23
Pró-Soluto	70,12%	21.082
Preço Raso (RS)	209.503	209.503
TCD	68,07%	24.689
VSO	27	27
Preço de Venda	**237.315**	**237.315**
Elasticidade	-1,333%	-1,333%
Preço de Venda Final	**234.193**	**234.193**

Preço Raso (R$)	**209.503**
% de Raso	**89,46%**
Raso Todas as Fases	**209.503**
Nominal Todas as Fases	**234.193**

1

Análise de Riscos	Farol IM
IM avalia o Preço Vision como **factível**.	

1) I.M está de acordo com o preço Vision, tendo em vista que, o projeto está em uma região com ótimos indicadores sociodemográficos, como renda e PEA/Dia, o mesmo também se encontra próximo de pontos de interesses como estação de trem, terminal de ônibus, hospital, escola, mercado, e o aeroporto Galeão, e etc.

Conforme consta no slide "Panorama de Concorrência", os concorrentes da região vendem em um target de preço e renda acima do previsto para o Produto Tenda.

	Preço Real					Preço Normalizado (23m)	
	Avaliação	Preço Raso	Renda Média	VSO	PSOL	Δ PSOL	Preço Raso
Elevato Bonsucesso	230.202	202.104	4.044	23	27	-4.000	198.104
Elevato Av. Brasil	240.000	209.503	3.598	27	23	-	209.503
Elevato Ramos*	240.000	209.708	3.524	28	24	-990	209.708
Elevato Madureira*	250.000	215.480	3.894	22	21	2.040	217.520
Mirante Boa Vista*	308.756	242.283	4.981	25	24	-1.160	242.283

Análise de Preço

Informações Viabilidade

Projeto:	Elevato Brasil
Tipo:	**Faixa 2**
Método	**Vision**
Avaliação	240.000
Renda Inicial (VF)	3.598
Renda Final*	-

Tipo:	VF	R$
Ato	0,53	1.891
FGTS	0,52	1.856
Financiamento	94,58%	176.841
Subsídio	327,59%	7.833
Prazo de Pró-soluto	23	23
Pró-Soluto	70,12%	21.082
Preço Raso (RS)	209.503	209.503
TCD	68,07%	24.689
VSO	27	27
Preço de Venda	**237.315**	**237.315**
Elasticidade	-1,333%	-1,333%
Preço de Venda Final	**234.193**	**234.193**

Preço Raso (R$)	**209.503**
% de Raso	**89,46%**
Raso Todas as Fases	**209.503**
Nominal Todas as Fases	**234.193**

1

Análise de Riscos	Farol IM
Ciclo avalia o Preço Vision como **factível**.	

- Pareceres
- Análise da Mancha e Implantação
- Prospecção
- Operações
- Inteligência de Mercado
- Financeiro

Informações Gerais – Consolidado

Elevato Brasil – RJ – Região Metropolitana > 100mil RJ

Datas e Prazos

	Compra	Lançamento	Início Obra	Término Obra	LÇTO até IO	IO até TO	Chaves	LÇTO até Chaves
Fase única	nov-24	jul-26	jan-27	jul-28	6 meses	18 meses	jul-29	36 meses

Terreno e Incorridos

TOTAL (R$ + Perm.):	10,11 MM	**Incorrido Terreno:** 0,55 MM	**Área do Terreno (100%):**	5.909 m²	**Área Líquida do Terreno:** 4.902 m²
Cash:	1,55 MM		**Custo de terreno m²:**	1.711,0	**Custo de terreno m² Área Líquida:** 2.062,7
Permuta Financeira:	8,56 MM (7,40%)		**VaR 25 (R$ mil):**	0	**Fração Terreno/Terreno + Custo Obra (%VGV):** 8,7% / 50,9%
Permuta Física:	0,00 MM (0,00%)		**VaR 26 (R$ mil):**	0	**CA Máx/Proj.** 7,0 / 4,0
Ato / %VGV:	0,55 MM / 0,5%		**Incorrido de Construção:**	0,00 MM	**Incorridos de Incorporação:** 0,01 MM

Vendas

Fases	Nº Pavimentos	Preço Raso Unit.	Qtde	Preço Unit.	Aval. CEF	Cond. Parcela	% Pró-soluto	% TCD
Fase Única	T+17	209.505	494	234.192	240.000	94,6%	70,1%	68,1%

Unidades Totais:	494	**Preço Médio:**	234.192	**Renda Média:**	3.598	**ITBI+Emol. Unit. Médio:**	3.129
Unidades Tenda:	494	**Avaliação Média:**	240.000	**Ato:**	1.907 (0,53 Salários)	**Custo do Ciclo Unit.:**	16.146
VSO:	27 Unidades	**VGV Total:**	115.691.006	**FGTS:**	1.871 (0,52 Salários)	**Preço Raso Médio:**	209.483
RET Médio:	3,3%	**VGV Tenda:**	115.691.006	**% em RET 1%:**	25%	**Adc. Tx. de Aceleração Médio:**	1.391

Construção

Custo Total Unit.:	98.687	**Eventuais:**	4,00%	**Área priv (m²):**	34,10	**Gape / Mês Unit.:**	11,08

Resultado

LI (R$):	**15.018.222**	**LI:**	**20,18%**	**Exposição de Caixa (R$):**	**15.646.591**	**Margem Bruta Econômica:**	**40,21%**
TIR:	**99,66%**	**LI Aprovação:**	**20,00%**	**Ger. Caixa 12 meses (R$):**	**(2.840.548)**	**Margem Bruta REF:**	**43,26%**
Exposição de Caixa:	**12,81%**	**Δ LI:**	**0,18%**	**Ger. Caixa 24 meses (R$):**	**(13.452.773)**	**Margem Rasa Econômica:**	**32,38%**
Payback Contingente (21 m):	**19 m/ (-2 m)**	**LI Resiliência:**	**13,07%**	**Ger. Caixa Marginal (R$):**	**32.934.626**	**Margem Rasa REF:**	**36,58%**
Payback Consolidado:	**19 meses**					**Margem de Contribuição Econômica:**	**28,47%**

Informações Gerais – DRE

R$ Mil - Valores Nominais - Compra	Elevato Brasil	
	Nominal	%
Receita	122.162	100,0%
PIS/COFINS	(2.173)	1,8%
Custo Total	(71.745)	59,8%
Custo Terreno	(10.500)	8,8%
Custo Relacionados a Terreno	(1.505)	1,3%
Custos de Incorporação	(2.054)	1,7%
Custo de Construção	(57.687)	48,1%
Lucro Bruto Econômico	48.243	40,2%
Custo para Rateio	-	0,0%
Lucro Bruto Contábil	48.243	40,2%
Despesas de Selling	(11.277)	9,4%
Contingência	(2.810)	2,3%
Margem de Contribuição	34.157	28,5%
IR e CSLL	(1.778)	1,5%
Margem Líquida	32.379	27,0%
Lucro Bruto REF Unit.	109.883	43,3%
Lucro Raso REF Unit.	83.109	36,6%

R$ Mil - VPL - Compra	Elevato Brasil	
	VP	%
Receitas	74.412	100,0%
PIS/COFINS	(1.304)	1,8%
Custos e Despesas Totais	(58.090)	78,1%
Custo Terreno	(6.803)	9,1%
Custo Relacionados a Terreno	(1.239)	1,7%
Custos de Incorporação	(1.650)	2,2%
Custo de Construção	(38.307)	51,5%
Despesas de Selling	(8.100)	10,9%
Contingência	(925)	1,2%
IR e CSLL	(1.067)	1,4%
Lucro Imobiliário	15.018	20,2%

Informações Gerais – Comparativo

Comparativo dos Estudos - Consolidado	Anterior	Atual	Atual vs Anterior	Δ%
Data Estudo:	dezembro-24	junho-25	6 Meses	N/A
Lançamento:	julho-26	julho-26	0 Meses	N/A
Uhs:	494	494	-	0,0%
Preço Nominal:	233.711	234.192	482	0,2%
Preço Raso:	210.731	209.483	(1.248)	-0,6%
Preço Nominal Inflacionado:	257.719	254.004	(3.716)	-1,4%
Preço Raso Inflacionado:	232.379	227.230	(5.149)	-2,2%
Renda Média:	3.524	3.598	74	2,1%
RET Médio:	4%	3,3%	-0,8 p.p.	-18,8%
% em RET 1%:	0%	25,0%	25,0 p.p.	
VSO:	27	27	-	0,0%
ITBI/Emol. Inf (Unit)[2]:	3.721	4.810	1.089	29,3%
Avaliação:	240.000	240.000	-	0,0%
Prazo construção F1:	19	18	(1)	-5,3%
Prazo de Pró-Soluto F1:	24	23	(1)	-4,2%
Custo Total Inf (Unit):	159.044	145.233	(13.810)	-8,7%
Custo Construção (Unit):	104.914	98.687	(6.227)	-5,9%
Custo Construção Corrigido:	104.499	98.687	(5.812)	-5,6%
Fração de construção:	45%	42,1%	-2,6 p.p.	-5,8%
INCC Folha Rosto:	1.153,73	1.184,46	31	2,7%
Custo Terreno Inf:	10.500.000	10.500.000	0	0,0%
Custo Relacionados a Terreno (Unit):	3.324	3.046	(279)	-8,4%
Fração do Terreno[1]:	8,7% / 53,6%	8,7% / 50,9%	0,0 p.p.	0,0%
Custo de Incorp. por uh:	5.021	4.158	(863)	-17,2%
ITBI/Emol. Inf (Total)[2]:	1.838.115	2.376.327	538.212	29,3%
Custo do Ciclo (Unit):	16.071	16.146	74	0,5%
LI Resiliência:	12,7%	13,1%	0,4 p.p.	3,3%
Lucro Imobiliário:	17,3%	20,2%	2,8 p.p.	16,3%
LI Resiliência:	12,7%	13,1%	0,4 p.p.	3,3%
Exposição de caixa:	12,1%	12,8%	0,7 p.p.	5,8%
TIR:	86,9%	99,7%	12,7 p.p.	14,6%
Margem Bruta REF:	38,8%	43,3%	4,4 p.p.	11,4%
Margem Bruta Econômica:	34,7%	40,2%	5,5 p.p.	16,0%
Margem Rasa REF:	32,2%	36,6%	4,4 p.p.	13,8%
Margem Rasa Econômica:	27,0%	32,4%	5,4 p.p.	19,8%
Margem Contribuição Econômica:	25,1%	28,5%	3,3 p.p.	13,3%
Payback Contingente (Régua 21 m):	19 m/ (-1 m)	19 m/ (-2 m)	0	0,0%
Payback Consolidado:	19 Meses	19 Meses	0 Meses	0,0%

[1] Valor do terreno contratual

[2] ITBI com taxa de Aceleração

Obrigado