Tenda

sua próxima conquista

Comitê Essencial

Regional: Itaquaquecetuba

Projeto: Cuiabinho

Data Comitê: 23/06/2025

One Page – Cuiabinho

[1]

Cidade	Itaquaquecetuba	**Mancha de demanda**	SP - ITA - Itaquaquecetuba
Regional	SPRM	**Cluster MPR**	1 - Vermelho
Cenário de Aprovação	Aprovação	**Tipo de Aprovação**	Consolidado
Fase Anterior	N/A		
Tipo de Comitê	Essencial	**Versão da VF**	Versão 1.0: Jun

[2]

Unidades (% Vagas)	499 (50%)	**CA Máx | Proj**	4,0 | 1,3
Tipologia	F2E - Concreto	**Escritura**	jan-27
Fases	1 fases	**Lçto | Duração (m)**	abr/27 | 26

[3]

Valor Líquido do Terreno (% VGV)	4.144 (3,7%)	**Un. Perm. Fís (% Ter)**	0 (0,0%)
Cash (Correção)	0 (N/A)	**%VGV Perm Fin Líquida (% Ter)**	3,7% (100,0%)
Valor R$/m²	422	**VAR (%VGV)**	000 (0,0%)

Custo Construção (%VGV)	51.052 (45,4%)	**Indireto Unit.**	19.654
Prazo da Obra (meses)	20	**Torre Unit.**	56.462
Custo Total Unit. | Corrigido (LPU):	102.308 | 102.836 (89)	**Infra Unit.**	14.406
Início de Obra	out-27	**Fundação Unit.**	8.425

[4]

Preço Nominal Unit.	225.244	**VSO**	28
Preço Raso Unit.	203.723	**Referência**	Vision
Avaliação Unit.	225.030	**Renda (% em RET 1%)**	3.200 (37,5%)



[5]

LI (Régua):	**22,1% (20,0%)**	**Margem Bruta Econômica:**	40,9%
LI Resiliência:	15,6% (N/A)	**Margem Rasa Econômica:**	33,8%
Margem Bruta REF:	44,1%	**Margem Contribuição Econômica:**	29,2%
Margem Rasa REF:	**38,2%**	**Exposição (% VGV):**	13.826 (11,3%)
TIR:	131,1%	**VGV Total:**	112.397
Payback Contingente (21 m) :	**19 m/ (-2 m)**	**Ger. Caixa 12 meses (R$):**	-
Payback Consolidado:	19	**Ger. Caixa 24 meses (R$):**	(1.978)

Destaques

[1] Localização: Está na Estrada do Cuiabá em **Itaquaquecetuba (RMSP)**, onde nossa última entrega aconteceu em 2017 (Veredas de Itaquá). Região com grande potencial de crescimento, em fase de aprovação de uma nova legislação permitindo um maior potencial aos produtos destinados a baixa renda e em todo município; na lei atual, apenas dois bairros tem a liberação para HIS com as dimensões da nossa tipologia.

[2] Implantação: Terreno de 61 mil m², onde será desmembrado um lote de 12.500 m² para implantação do nosso condomínio, com 499 uh (T+17 14pp em L). Apesar de não ter limite de gabarito, a lei atual limita o número de unidades por condomínio, o número de pps por pavto e exige 50% de vagas. Oportunidade: A nova lei de uso do solo e parcelamento está prevista para ser publicada ainda em 2025 e pode trazer mudanças que trariam ganhos no adensamento do projeto.

[3] Condição Comercial:

a) 100% em Permuta financeira equivalente a fração fixa e não variável de 20 unidades; sobre o valor desta permuta bruta estimado no contrato em 4,6MM, será descontado o percentual de 8%; Na viabilidade este valor representa atualmente 4,01% de permuta bruta e 3,7% de permuta líquida estimados em R$ 4,1MM;
b) Não há condição de preço mínimo, de correção ou prazo de quitação;
c) Como a negociação fixou a permuta financeira equivalente a 20unid, o permutante não participará de variações.
d) OBS: Aproximadamente R$ 279/CA e R$ 360/m2 (base valor terreno de 4,5MM)
e) A corretagem está sendo paga pelos vendedores;
f) Garantia: Confissão de dívida.

[4] Preço de Venda: Sem lançamentos na região há 9 anos, realizamos análises com as equipes de Ciclo e IM para definição de preço: 233k nominal com vaga e 214k de raso; 217k nominal sem vaga e 193k de raso. Ainda assim, estamos bem abaixo do último lançamento da MRV (T+4), com preços de 234k e 260k (sem e com vaga, respectivamente) em uma região com infraestrutura inferior.

[5] Resultado: Projeto acima da régua de 20% de LI e com todos os estudos técnicos concluídos. Seguimos para o Comitê Essencial, uma vez que a Lei Complementar necessária para viabilizar o projeto ainda não foi publicada, com previsão até agosto/25. Após a publicação será possível emitir a diretriz urbanística e avançaremos para o Comitê Ampliado.

Pareceres

Análise da Mancha e Implantação

Prospecção

Operações

Incorporação

Inteligência de Mercado

Financeiro

Anexos

Pareceres

Área	Riscos Associados	Parecer	Criticidade
Jurídico Aquisição	De acordo com a DD prévia foram localizados aproximadamente 540 processos em nome da proprietária tabular dos quais 181 processos já foram esclarecidos, estando extintos e arquivados, desta forma, solicitamos esclarecimentos a mesma, para mensurar eventual o passivo, além de apresentar o lastro patrimonial para garantia das obrigações. Considerando que ao analisarmos a matrícula atualizada do imóvel, constatamos não haver qualquer ônus ou constrição relacionados a processos judiciais, além dos esclarecimentos já realizados, entendemos ser viável darmos andamento aos próximos atos a serem praticados para a efetiva aquisição do terreno, bem como na DD detalhada sobre a proprietária, antecessores e estudos jurídico e técnico do imóvel.	Ok com ressalvas	
Legalização	Apesar de já termos lançado no município anteriormente, foi necessário reanalisar toda a legislação local, e ainda permanecem dúvidas que serão esclarecidas ao longo do processo de legalização. A implantação depende de nova lei para viabilizar HIS R4 na região, já discutida com o prefeito Eduardo Boigues. Também será necessário realizar o processo de desdobro do terreno e doação de área institucional, a ser descontada da área remanescente do vendedor, ou seja nossa implantação e negociação já contempla a área líquida, pós doações. Não há regramento legal de contrapartida, mas foi sinalizado valor aproximado de R$ 400 mil. O fluxo de licenciamento ainda não está totalmente claro, o que exige atenção contínua.	Ok com ressalvas	
DPP	Sem riscos associados	Ok	
IM	IM avalia o Preço Vision como factível.	Ok	
EE	Ok, para comitê essencial.	Ok	
Comercial/Ciclo	Ciclo avaliou Preço e VSO como factíveis.	Ok	

Pareceres

Análise da Mancha e Implantação

Prospecção

Operações

Incorporação

Inteligência de Mercado

Financeiro

Anexos

Localização – Estrada do Cuiabá – Jardim Caiubi – Itaquaquecetuba- SP

Rei Lar Supermercados

E. E. Dr Ervin Horvath

Unidade de Pronto Atendimento 24h

Higa's Supermercados

Escola Estadual Joaquim Gonçalves

Complexo Esportivo Rei Pelé (CEC)

Padaria JK

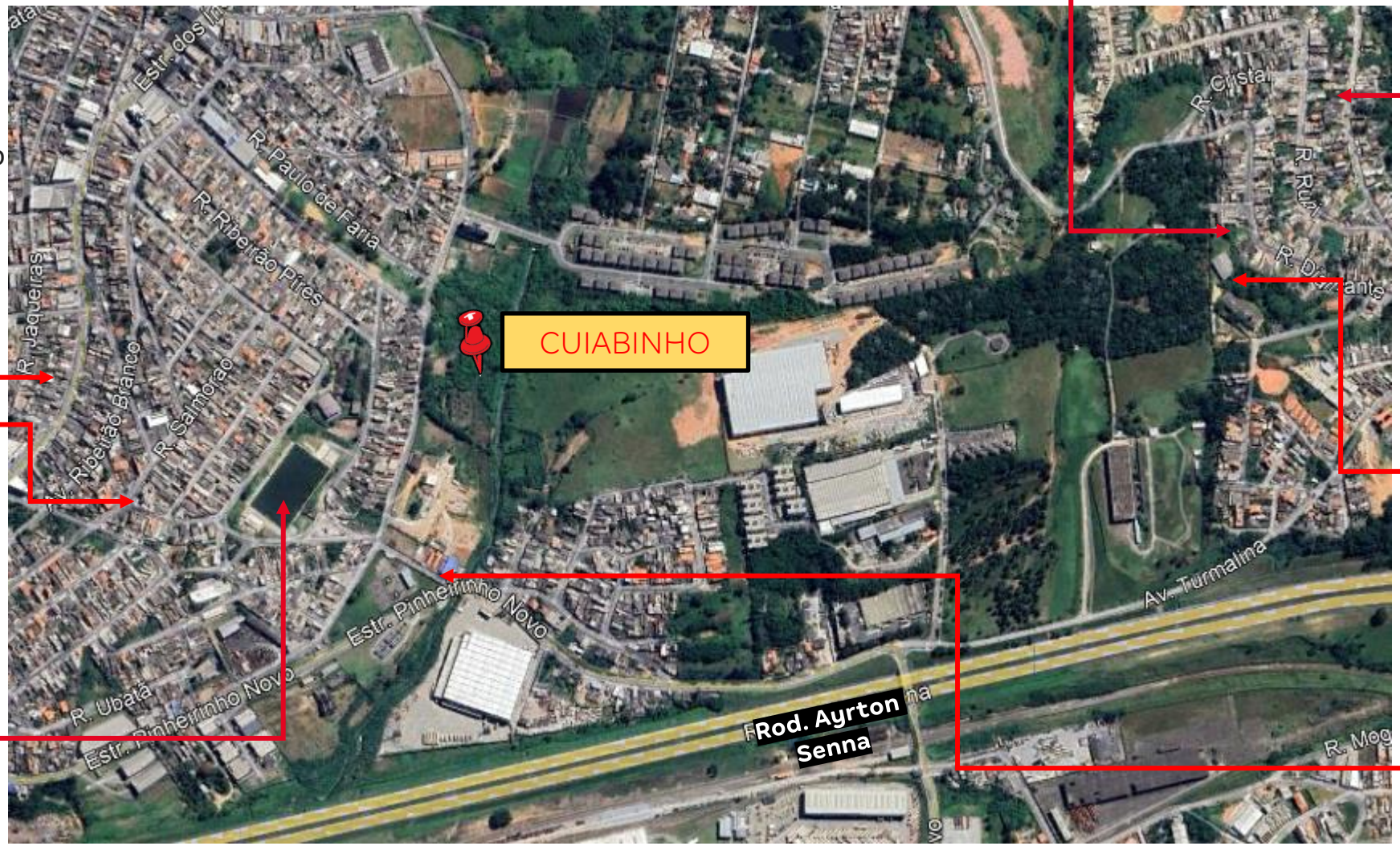

Localização – Estrada do Cuiabá – Jardim Caiubi – Itaquaquecetuba- SP

CUIABINHO

Área a ser desmembrada (aproximada)

Área total

Mancha de Demanda

MANCHAS DE DEMANDA • ITA – Itaquaquecetuba
Landbank 1. Cuiabinho

Cluster MPR – (Comitê)
Cluster 1 - Vermelho

Região
Metropolitana

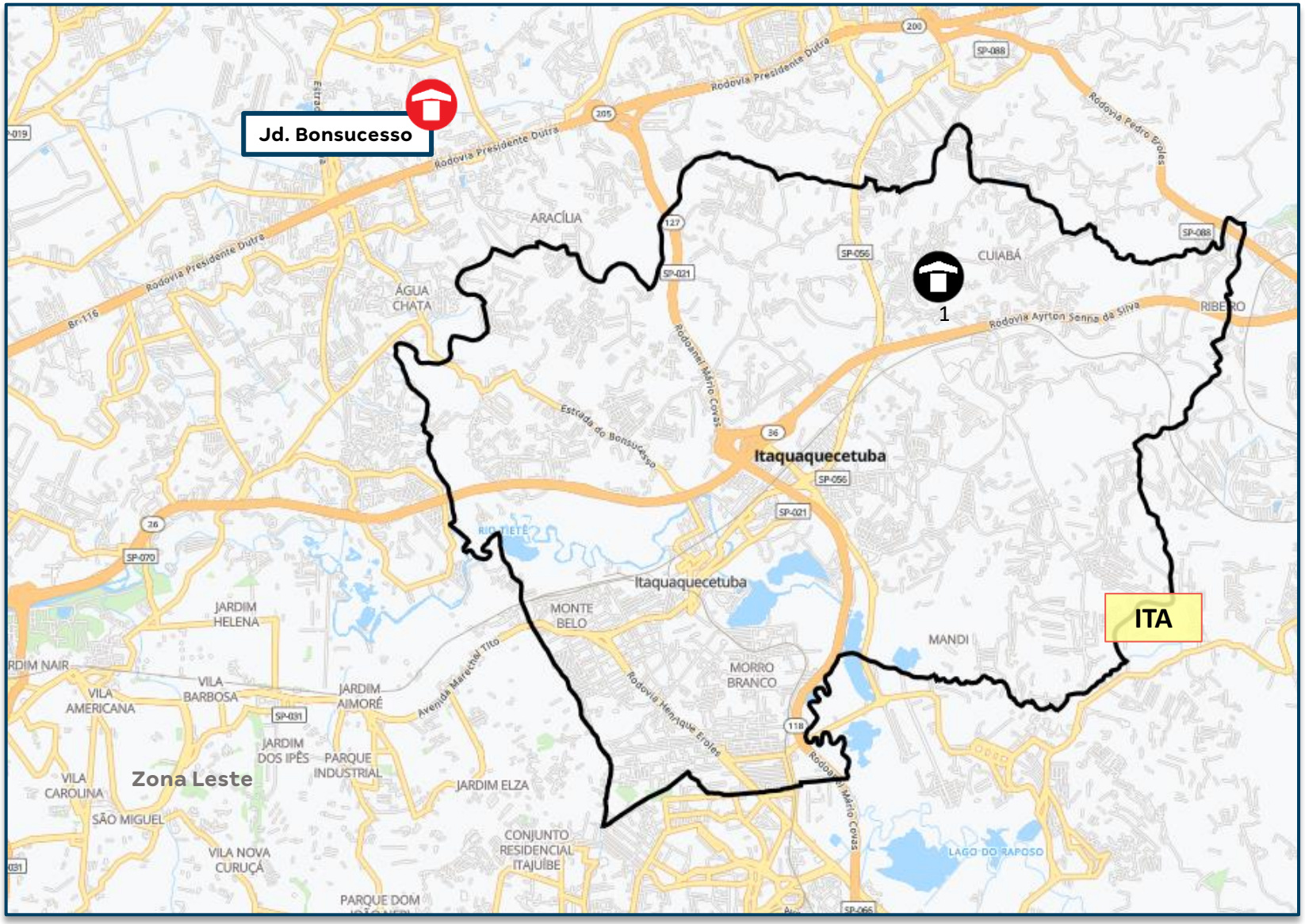

Lançados *LandBank* *Comitê*

PRODUTO

Projeto Cuiabinho
Investimento

Informações Gerais – Condomínio Único		
Terreno	Área terreno	12.500,00m²
	Menor poligonal	12.500,00m²
	APP	Sim – 1.816,00m²
	Área liquida	10.684,00m²
	Zoneamento	ZUEC
	CA máximo	4,00
	CA projetado	1,29
	CA Líquido	1,51
	Gabarito máximo	120 m
Geral	Total UH	499*
	Total de vagas	(50%) 250
Tipologia	Tipologia	V0200 14PP-LF-C
	Gabarito	T+17
	Lâmina	02 X 14PP-LF-C
	Área privativa	31,86m²
Condomínio	Unidade PCD	10
	Unidade lazer | técnica	03 | 02
	Torre	02
	Fase	Única
Lazer	Lazer coberto	2x Salão de Festas, Churrasqueira
	Lazer descoberto projetado	22.495m² (5m² por UH)

*Número de unidades limitado a 499UH,
para evitar doações e contrapartidas

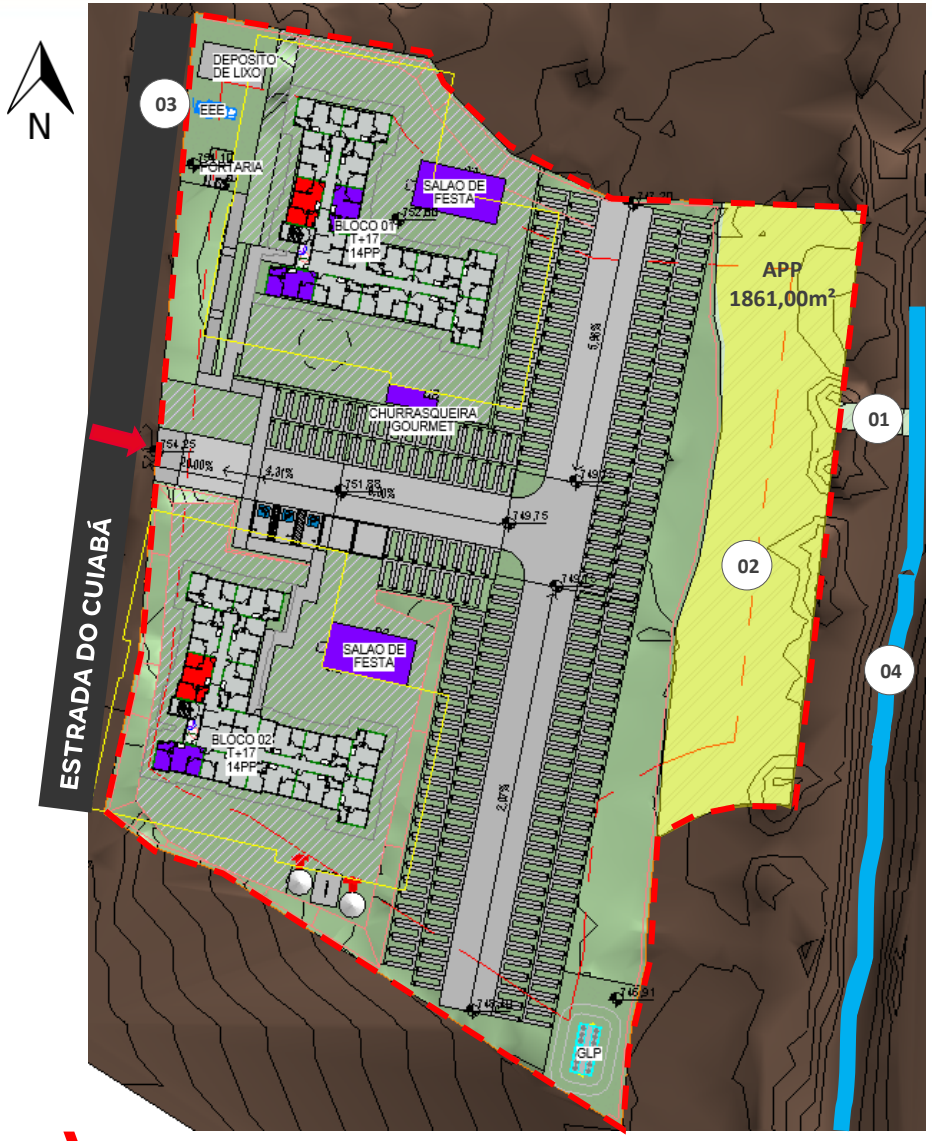

ESTUDO DE MASSA

LEGENDA:

01 FNA Drenagem
02 APP
03 EEE
04 CORPO HIDRICO

PRODUTO

Projeto Cuiabinho
Investimento

	Descrição	Criticidade	Parecer
Usabilidade	**Acesso Empreendimento**	🟢	
	Percurso do pedestre até torre	🟢	

Diferencial produto	**Prime**	Não	
	Supercondomínio	Não	
	Atributos Infra	Não	
	Atributos Torre	Não	
	Edifício Garagem	Não	

	Descrição	Criticidade	Parecer
Material analisado	• Ficha Briefing;	🟢	
	• Diretriz Sabesp;	🟡	• O estudo contempla elevatória de esgoto, e ligação de esgoto depende de conclusão de obras da SABESP
	• Planialtimétrico;	🟢	
	• Sondagem (com análise de especialista interno);	🟢	
	• Hidrogeológico;	🟢	
	• Hidrológico	🟢	
Projeto	• Projeto desenvolvido considerando área liquida de 12.500m²	🟡	• Área será desmembrada de área maior, os limites considerados no estudo podem sofrer alterações a depender de FNA referente a rede de esgoto que atravessa o terreno no limite da nossa poligonal aprovada por Sabesp, e análise de prefeitura e definição de APP.
	• Projeto considera vaga presa.	🟡	• Lei não faz menção a vaga presa, porém, foram observados vários exemplos de concorrentes no município

Pareceres

Análise da Mancha e Implantação

Prospecção

Operações

Incorporação

Inteligência de Mercado

Financeiro

Anexos

Condições do Negócio

➢ VALOR DO NEGÓCIO / CONDIÇÃO COMERCIAL

- 100% em Permuta financeira equivalente a fração fixa e não variável de 20 unidades; sobre o valor desta permuta bruta estimado no contrato em 4,6MM, será descontado o percentual de 8%; Na viabilidade este valor representa atualmente 4,01% de permuta bruta e 3,7% de permuta líquida estimados em R$ 4,1MM;
- Não há condição de preço mínimo, de correção ou prazo de quitação;
- Como a negociação fixou a permuta financeira equivalente a 20unid, o permutante não participará de variações.

OBS: Aproximadamente R$ 279/CA e R$ 360/m2 (base valor terreno de 4,5MM)

➢ PRAZOS CONTRATUAIS

- Etapa I: Prazo 12 meses para baixa da hipoteca pelos vendedores (previsão out/25)
- Etapa II: Em até 6 meses da Etapa I para resolutivas técnica, jurídica e financeira;
- Etapa III: Em até 12 meses após a superação da Etapa II para aprovação de projeto de desmembramento:
- Etapa IV: Em até 12 meses após a superação da Etapa III para aprovação de projeto, contratação CEF, análise técnica, financeira e comercial para o lançamento do empreendimento;

➢ PREVISÃO EM CONTRATO DE DESCONTOS DO PREÇO

- Limite pré aprovado de 5% do valor do negócio (R$ 230.000,00) para regularizações que se fizerem necessárias à aprovação do projeto e realização dos demais atos necessários à consecução do Empreendimento perante a Prefeitura Municipal e os demais órgãos competentes
- Limite pré aprovado de 5% do valor do negócio (R$ 230.000,00) para adoção de medidas visando sanar os Passivos Ambientais, tais como, exemplificativamente, sem qualquer limitação, medidas visando remediar/descontaminar/conter contaminação, plano de intervenção e/ou reabilitação
- TAC (Termos de Ajustamento de Conduta)/TCA (Termo de Compromisso Ambiental) no intuito de reparar o dano ambiental, sem limite de valor

➢ GARANTIAS

- Proprietário: Confissão de dívida
- Tenda: N/A

➢ CORRETAGEM

- Por conta dos vendedores

Pareceres

Análise da Mancha e Implantação

Prospecção

Operações

Incorporação

Inteligência de Mercado

Financeiro

Anexos

Custo de Construção – SIMULADOR

PARÂMETROS

Empreendimento:	Cuiabinho			INCC base:	1.178,39
Produto / Selo:	F2E Modular	Contenção:	Nível 2	Prazo pré forma:	5,4
Pavimentos Médio:	14	Terraplenagem:	Nível 3	Prazo forma:	5,1
Torres:	2	Varanda %:	0%	Prazo pós Forma:	9,0
PPs médio:	17,8	Piscina:	Não	Prazo total:	20,0
Unidades Construídas:	499	ETE:	Não	EEE:	Sim

Infra Externa

Viário (m):	46	Extensão Esgoto (m):	30
Drenagem (m):	30	Extensão Água (m):	41

Obras ref. contenção

Portal Do Parque
Viva City Jaraguá F1
Life Jaguare
Palermo

Obras ref. Terraplenagem

Buritis
Farol Da Cantareira
Reserva Das Andorinhas
Viva Parque Do Carmo
Palermo

Custo de Construção - SIMULADOR

ESTIMATIVA

DADOS DA OBRA		BASES		PRAZOS DE OBRA	
Regional:	SP	Data:	junho-25	Pré Forma:	5,4 meses
Endereço:		Revisão:	R00	Estrutura:	5,1 meses
Total de UH:	**499**	LPU:	LPU 89	Pós Forma:	9,0 meses
Total Torres:	2	LVS:	março-25	**TOTAL:**	**20,0 meses**
Produtos:	F2E Modular	INCC:	1.178,386		
Tipologia:	MODULAR 10PP/16PP T+15			Jogos de Formas:	2
				Takt:	2+2

CUSTOS DE CONSTRUÇÃO

	CUSTO	R$ / UND
CUSTO TOTAL I	**R$ 49.986.704**	**R$ 101.188**
INDIRETO	R$ 9.709.161	R$ 19.654
TORRE	R$ 27.892.391	R$ 56.462
INFRA	R$ 7.116.413	R$ 14.406
FUNDAÇÃO	R$ 4.162.082	R$ 8.425
ETE	R$ 0	R$ 0
EEE	R$ 246.394	R$ 499
CONTENÇÃO	R$ 74.866	R$ 152
TERRAPLENAGEM	R$ 785.397	R$ 1.590

CRITÉRIOS DE INPUT DO SIMULADOR

ETE: Retirada de acordo com a diretriz da Sabesp e validação de Getec/Leg
EEE: Será necessário para lançar o esgoto para a rua

Custo de INFRA – SIMULADOR

CUSTO TOTAL II	R$ 553.603	R$ 1.121
VIÁRIO	R$ 76.076	R$ 154
DRENAGEM	R$ 182.160	R$ 369
EXTENSÃO ELÉTRICA	R$ 100.000	R$ 202
EXTENSÃO HIDRÁULICA	R$ 195.367	R$ 395

CRITÉRIOS DE INPUT DO SIMULADOR

- Viário: considerada toda a testada do empreendimento
- Drenagem: lançamento por gravidade no córrego dos fundos
- Pontos de interligação de água e esgoto de acordo com a diretriz da Sabesp

- Ponto de ligação de água
- Ponto de ligação de esgoto
- Saída da drenagem

Pareceres

Análise da Mancha e Implantação

Prospecção

Operações

Incorporação

Inteligência de Mercado

Financeiro

Anexos

Demanda e Distribuição da Mancha

Potencial de Demanda			Lançados		Lançados + Landbank	
Mancha	CÓD.	Shr.	ANO	MÊS	ANO	MÊS
Itaquaquecetuba	ITA	50%	556	46	667	56

Empreendimento	Renda	Lançamento	abr/27	mai/27	jun/27	jul/27	ago/27	set/27	out/27	nov/27	dez/27	jan/28	fev/28	mar/28	abr/28	mai/28	jun/28	jul/28	ago/28	set/28	out/28	nov/28	dez/28	jan/29
Cuiabinho	3.202	abr-27		28	28	28	28	28	28	28	28	28	28	28	28	28	28	28	28	28	23			
Total de Vendas Lançados			0	0	0	0	0	0	0	0	0	0	0	0	0	0	0	0	0	0	0	0	0	0
Total de Vendas Lançados + Landbank			0	28	28	28	28	28	28	28	28	28	28	28	28	28	28	28	28	28	23	0	0	0

Parecer de I.M sobre a mancha:

O projeto analisado em comitê está em linha com o potencial teórico de demanda calculado para a mancha. (Total Lanç + Landbank)

Canibalização:

Sem Risco de Canibalização

Cuiabinho | Mapa Concorrência

		Cuiabinho	Mirante Da Colina	Mirante Do Campo
		TENDA	MRV	MRV
	Distância Tenda (km)		5,81Km	5,32 Km
Região 1 Km	População	20.261	22.274	9.957
	Dens. Demográfica	6.491	7.136	3.190
	Renda (R$)	3.366	2.892	3.864
	Classe Social	C1 (2.7k a 4.6k)	C1 (2.7k a 4.6k)	C1 (2.7k a 4.6k)
	PEA Dia	6.494	6.869	8.973
Quantitativo	Lançamento	abr/27	10/2024	12/2023
	Unidades	499	480	240
	Estoque	499	292	0
	VSO	28	27	23
	Stockout	18	11	0
Qualitativo	Condomínios	1	1	1
	Torres	-	10	6
	Gabarito	T+17	T+4	T+4
	Plantas (m²)	32m²	40,82m² e 40,82m²	40,88m² e 40,83m²
	Tipologia	2 Dorms	2 Dorms	2 Dorms
	Opções	Não	Garden	Garden
	Varanda	Não	Não	Não
	Suite	Não	Não	Não
	Dif. Entrega	Não	Não	Não
	Vagas	50% de Vagas	Com vaga	100% Com vaga
	Lazer	Salão De Festas, Churrasqueira Gourmet, Playground Baby, Plaground Kids, Praça De Jogos, Quadra Gramada, Fitness Externo.	Tem Garden, Bosque, Campo de Futebol, Cinema, Fireplace, Praça, Salão de Jogos,	Tem Garden, Bosque, Campo de Futebol, Cinema, Praça, Salão de Jogos, Sauna Seca,

Tipologias	Empreendimento	Cuiabinho		Mirante Da Colina - Com Emcash			Mirante Do Campo - Sem Emcash
	Tipologia	HIS	HIS - Vaga carro	Sem vaga	Com vaga	Garden c/vaga	Com vaga
	Preço Nominal	220.074	230.393	231.049	249.005	277.456	238.323
	CEF	170.746	183.351	170.041	190.896	195.857	190.658
	Renda	2.899	3.499	3.223	3.693	4.404	4.138
	% de Unidades	49%	51%	12%	68%	20%	-
	Dif Renda			324	194	-	639
	Farol de Factibilidade			●	●	-	●

Farol Renda
● Acima de 300
● Entre 0 e 300
● Abaixo de 0

Diagnóstico Concorrência

- Os empreendimentos mapeados são da MRV e estão localizados fora do raio de 5 km.
- O empreendimento Mirante do Campo não possui unidades disponíveis. Mas o projeto conseguiu atrair um perfil de cliente com renda superior ao estimado no parecer, mantendo um volume de vendas próximo ao previsto para um produto da Tenda.
- Já o empreendimento Mirante da Colina, localizado em uma região similar, performou o volume de vendas projetado para Cuiabinho (Tenda) e atua com um target de preço e renda acima do estimado no parecer.

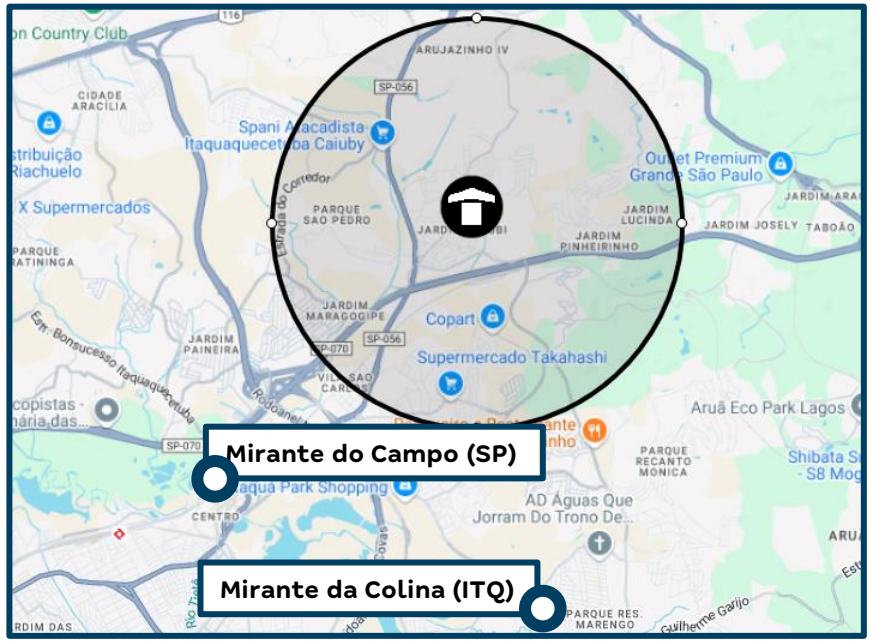

Simulação de Preço

Informações Viabilidade

Projeto:	Cuiabinho			
Tipo:	**HIS**		**HIS - Vaga carro**	
Método	**Vision**		**Vision**	
Avaliação	210.000		240.000	
Renda Inicial (VF)	2.899		3.499	
Renda Final*	-		-	
% RET1	50%		25%	
Tipo:	**VF**	**R$**	**VF**	**R$**
Ato	0,53	1.542	0,68	2.377
FGTS	0,72	2.099	0,64	2.243
Financiamento	95,37%	157.655	96,27%	177.242
Subsídio	107,43%	10.992	137,80%	3.866
Prazo de Pró-soluto	25	25	25	25
Pró-Soluto	90,29%	23.775	80,63%	25.625
Preço Raso (RS)	196.063	196.063	211.353	211.353
TCD	82,17%	24.011	53,98%	19.040
VSO	14	14	14	14
Preço de Venda	**220.074**	**220.074**	**230.393**	**230.393**
Elasticidade	0,000%	0,000%	0,000%	0,000%
Preço de Venda Final	**220.074**	**220.074**	**230.393**	**230.393**
Preço Raso (R$)	**196.063**		**211.353**	
% de Raso	**89,09%**		**91,74%**	
BP25 - Não Inflacionado	-		-	
BP25 - Inflacionado	-		-	

Análise de Preço

Informações Viabilidade

Projeto:	Cuiabinho
Tipo:	**Faixa 2**
Método	**Vision**
Avaliação	225.150
Renda Inicial (VF)	3.202
Renda Final*	-

Tipo:	VF	R$
Ato	0,61	1.964
FGTS	0,68	2.172
Financiamento	95,83%	167.547
Subsídio	122,77%	7.393
Prazo de Pró-soluto	25	25
Pró-Soluto	85,41%	24.709
Preço Raso (RS)	203.785	203.785
TCD	67,93%	21.501
VSO	28	28
Preço de Venda	**225.285**	**225.285**
Elasticidade	0,000%	0,000%
Preço de Venda Final	**225.285**	**225.285**
Preço Raso (R$)	**203.785**	
% de Raso	**90,46%**	

1

Análise de Riscos

Farol IM

IM avalia o Preço Vision como **factível**.

1) I.M está de acordo com o preço Vision, tendo em vista que, o projeto está em uma região com bons indicadores sociodemográficos, o mesmo também se encontra próximo de pontos de interesses como hospital, escola e etc.

Conforme consta no slide "Panorama de Concorrência", não foi mapeado concorrente dentro do raio de 5Km. Os empreendimentos mencionados estão localizados fora desse raio, no município de Itaquaquecetuba. Mesmo assim, apresentam um bom volume de vendas, performando um target de preço e renda acima do estimado no parecer.

Apesar de ser o primeiro empreendimento na mancha, com base no bom desempenho desses concorrentes, entendemos que o preço do Vision está adequado para atingir o volume de vendas esperado. Abaixo segue o comparativo de preço do Bonsucesso (Tenda), embora ele esteja localizado em outro município (Guarulhos), o projeto está em uma região metropolitana similar ao do Cuiabinho (vide o próximo slide), superando o volume de vendas projetado para comitê.

	Preço Real					Preço Normalizado (25m)	
	Avaliação	Preço Raso	Renda Média	VSO	PSOL	Δ PSOL	Preço Raso
Jd. Bonsucesso	**226.403**	**205.310**	**3.323**	**41**	**30**	**-5.250**	**200.060**
Cuiabinho	**225.150**	**203.785**	**3.202**	**28**	**25**	**-**	**203.785**

Análise de Preço

Abaixo segue o comparativo entre os empreendimentos Cuiabinho e Jd. Bonsucesso (Tenda). Apesar de estarem localizados em regiões distintas, ambos apresentam dados sociodemográficos similares, especialmente no que se refere à renda média e classe social predominante.

Empreendimentos	Cuiabinho	Jd. Bonsucesso
População	20.261	15.203
Dens. Demográfica	6.491	4.862
Renda	3.366	3.514
Classe Social	C1 (2.7k a 4.6k)	C1 (2.7k a 4.6k)
PEADia	6.494	12.624

Estudo de Mercado

TENDA
CUIABINHO

MRV
SAN SAINT VIRGINIA

MRV
MIRANTE DA COLINA

Distâncias

Cuiabinho x MRV Mirante da Colina	5 Km
Cuiabinho x MRV San Saint Virginia	9 Km

Estudo de Mercado (MRV Mirante da Colina)

PLANTA

- 2 quartos
- Área privativa

As imagens são meramente ilustrativas, buscando representar artisticamente o empreendimento. Móveis, objetos, revestimentos decorativos, equipamentos e demais acabamentos são apenas referências e não fazem parte do contrato de compra e venda da unidade. Consulte o memorial descritivo para obter detalhes sobre as características e materiais a serem entregues no empreendimento. Consulte mais informações no final do material.

PLANTA

- 2 quartos
- Apto. tipo

As imagens são meramente ilustrativas, buscando representar artisticamente o empreendimento. Móveis, objetos, revestimentos decorativos, equipamentos e demais acabamentos são apenas referências e não fazem parte do contrato de compra e venda da unidade. Consulte o memorial descritivo para obter detalhes sobre as características e materiais a serem entregues no empreendimento. Consulte mais informações no final do material.

IMPLANTAÇÃO 3D

IMPLANTAÇÃO

MIRANTE DA COLINA - IMPLANTAÇÃO

ÁREA DE LAZER
1. Salão de festas
2. Gourmet
3. Churrasqueira
4. Playground
5. Espaço kids
6. Pet place
7. Bicicletário
8. Instalações sanitárias lazer

ÁREA DE APOIO
9. Guarita
10. Apoio administrativo
11. Depósito de lixo
12. Castelo d´água
13. Casa de bombas
14. Reservatório de retenção
15. Espaço reservado para equipamento

ACESSOS
- Blocos
- Pedestre
- Veículos
- Serviço

RESIDENCIAL
- Área privativa

Concorrência 1

Incorporadora: MRV

Inf. Produto	Mirante da Colina
Data Lanç	Novembro/2024
Qtde de unidade	480
Estoque	295
Renda	2.800
Tipologias	Faixa 3

Preço	
Faixa 3 - 40,67 C/Vaga	260.990
Faixa 3 - 40,67 S/Vaga	234.990
Faixa 3 - 40,83 C/Vaga	281.990

Fluxo	
Ato	500
Prazo Pró-Soluto (via EMCASH):	-
% Pró-Soluto	30%
ITBI/TCD	não aplicável
% Parcela TCD	atrelada ao IPCA + 1%
Correção	IPCA + 1%

Concorrência 2

Incorporadora: MRV

Inf. Produto	San Saint Virginia
Data Lanç	01/07/2025
Qtde de unidade	320
Estoque	320
Renda	2.800
Tipologias	-

Breve Lançamento

Parecer do Ciclo

Ciclo avaliou Preço e VSO como factíveis. O projeto está em uma região estratégica na borda de São Paulo, e consolidada com diversos projetos da Tenda.

Pareceres

Análise da Mancha e Implantação

Prospecção

Operações

Incorporação

Inteligência de Mercado

Financeiro

Anexos

Informações Financeiras

Cuiabinho - SPRM - Região Metropolitana > 100mil SP

Datas e Prazos

	Compra	Lançamento	Início Obra	Término Obra	LÇTO até IO	IO até TO	Chaves	LÇTO até Chaves
Consolidado	out-24							
Cuiabinho sem vaga		abr-27	out-27	jun-29	6 meses	20 meses	abr-30	36 meses
Cuiabinho com vaga carro		abr-27	out-27	jun-29	6 meses	20 meses	abr-30	36 meses

Terreno e Incorridos

TOTAL (R$ + Perm.):	4,50 MM	**Incorrido Terreno:** 0,00 MM	**Área do Terreno (100%):**	12.500 m²	**Área Líquida do Terreno:** 10.684 m²
Cash:	0,00 MM		**Custo de terreno m²:**	360,4	**Custo de terreno m² Área Líquida:** 421,6
Permuta Financeira:	4,50 MM (4,01%)		**VaR 25 (R$ mil):**	0	**Fração Terreno/Terreno + Custo Obra (%VGV):** 4,0% / 49,4%
Permuta Física:	0,00 MM (0,00%)		**VaR 26 (R$ mil):**	0	**CA Máx/Proj.** 4,0 / 1,3
Ato / %VGV:	0,00 MM / 0,0%		**Incorrido de Construção:**	0,00 MM	**Incorridos de Incorporação:** 0,10 MM

Vendas

Fases	Nº Pavimentos	Preço Raso Unit.	Qtde	Preço Unit.	Aval. CEF	Cond. Parcela	% Pró-soluto	% TCD
Cuiabinho sem vaga	T+17	196.063	249	220.074	210.000	95,4%	90,3%	82,2%
Cuiabinho com vaga carro	T+17	211.353	250	230.393	240.000	96,3%	80,6%	54,0%

Unidades Totais:	499	**Preço Médio:**	225.244	**Renda Média:**	3.200	**ITBI+Emol. Unit. Médio:**	4.870
Unidades Tenda:	499	**Avaliação Média:**	225.030	**Ato:**	1.938 (0,61 Salários)	**Custo do Ciclo Unit.:**	14.179
VSO:	#REF!	**VGV Total:**	112.396.642	**FGTS:**	2.184 (0,68 Salários)	**Preço Raso Médio:**	203.723
RET Médio:	2,9%	**VGV Tenda:**	112.396.642	**% em RET 1%:**	37%	**Adc. Tx. de Aceleração Médio:**	750

Construção

Custo Total Unit. | Corrigido:	102.308 | 102.836	**Eventuais:**	4,00%	**Área priv (m²):**	32,00	**Gape / Mês Unit.:**	11,08

Resultado

LI (R$):	**14.355.259**	**LI:**	**22,06%**	**Exposição de Caixa (R$):**	**13.825.770**	**Margem Bruta Econômica:**	**40,87%**
TIR:	**131,10%**	**LI Aprovação:**	**20,00%**	**Ger. Caixa 12 meses (R$):**	**0**	**Margem Bruta REF:**	**44,06%**
Exposição de Caixa:	**11,27%**	**Δ LI:**	**2,06%**	**Ger. Caixa 24 meses (R$):**	**(1.977.533)**	**Margem Rasa Econômica:**	**33,85%**
Payback Contingente (21 m):	**19 m/ (-2 m)**	**LI Resiliência:**	**15,64%**	**Ger. Caixa Marginal (R$):**	**33.739.353**	**Margem Rasa REF:**	**38,16%**
Payback Consolidado:	**19 meses**					**Margem de Contribuição Econômica:**	**29,17%**

Informações Financeiras

R$ Mil - Valores Nominais - Compra	Cuiabinho		Cuiabinho sem vaga		Cuiabinho com vaga carro	
	Nominal	%	Nominal	%	Nominal	%
Receita	122.704	100,0%	59.927	100,0%	62.777	100,0%
PIS/COFINS	(1.940)	1,6%	(822)	1,4%	(1.119)	1,8%
Custo Total	(71.413)	59,1%	(35.566)	60,2%	(35.847)	58,1%
Custo Terreno	(4.525)	3,7%	(2.210)	3,7%	(2.315)	3,8%
Custo Relacionados a Terreno	(601)	0,5%	(300)	0,5%	(301)	0,5%
Custos de Incorporação	(3.038)	2,5%	(1.495)	2,5%	(1.543)	2,5%
Custo de Construção	(63.250)	52,4%	(31.562)	53,4%	(31.688)	51,4%
Lucro Bruto Econômico	49.350	40,9%	23.540	39,8%	25.811	41,9%
Custo para Rateio	-	0,0%	-	0,0%	-	0,0%
Lucro Bruto Contábil	49.350	40,9%	23.540	39,8%	25.811	41,9%
Despesas de Selling	(11.299)	9,4%	(5.516)	9,3%	(5.784)	9,4%
Contingência	(2.822)	2,3%	(1.378)	2,3%	(1.444)	2,3%
Margem de Contribuição	35.229	29,2%	16.646	28,2%	18.583	30,1%
IR e CSLL	(1.588)	1,3%	(672)	1,1%	(915)	1,5%
Margem Líquida	33.641	27,9%	15.973	27,0%	17.668	28,7%
Lucro Bruto REF Unit.	111.257	44,1%	105.960	42,8%	117.198	45,2%
Lucro Raso REF Unit.	87.090	38,2%	78.992	35,8%	95.820	40,3%

R$ Mil - VPL - Compra	Cuiabinho		Cuiabinho sem vaga		Cuiabinho com vaga carro	
	VP	%	VP	%	VP	%
Receitas	65.062	100,0%	31.538	100,0%	33.524	100,0%
PIS/COFINS	(1.014)	1,6%	(426)	1,4%	(589)	1,8%
Custos e Despesas Totais	(49.692)	76,4%	(24.600)	78,0%	(25.092)	74,8%
Custo Terreno	(2.296)	3,5%	(1.113)	3,5%	(1.183)	3,5%
Custo Relacionados a Terreno	(464)	0,7%	(232)	0,7%	(233)	0,7%
Custos de Incorporação	(1.902)	2,9%	(937)	3,0%	(965)	2,9%
Custo de Construção	(36.265)	55,7%	(18.096)	57,4%	(18.169)	54,2%
Despesas de Selling	(7.143)	11,0%	(3.487)	11,1%	(3.655)	10,9%
Contingência	(792)	1,2%	(387)	1,2%	(405)	1,2%
IR e CSLL	(830)	1,3%	(348)	1,1%	(482)	1,4%
Lucro Imobiliário	14.355	22,1%	6.512	20,6%	7.843	23,4%

Pareceres

Análise da Mancha e Implantação

Prospecção

Operações

Incorporação

Inteligência de Mercado

Financeiro

Anexos

AMBIENTAL + LEGALIZAÇÃO – Paramétrico de custos

REGIONAL RMSP

PARAMÉTRICO DE CUSTOS LEGALIZAÇÃO

ABERTURA	$ FINAL	
Compensação Ambiental	R$	848.600
Laudos, EIV, EIARIMA	R$	15.000
Emolumentos e Taxas	R$	25.000
Assessorias	R$	-
Cópias, Plotagens, Autenticações, etc...	R$	10.000
Contra Partida	R$	400.000
Projeto de criação e Legal	R$	18.500
Total	**R$**	**1.317.100**
		R$ 2.639/uh

CRITÉRIOS DE INPUT

Compensação ambiental: pelo levantamento arbóreo temos 540 árvores no terreno, foi feito o cálculo conforme indicação de legalização;

Contra Partida: não existe regramento na legislação atual, mas em consulta na Prefeitura, o secretário nos passou o valor de R$400k para este projeto; **OBS: contemplado na viabilidade.**

Remediação: já temos o laudo preliminar e não temos risco de contaminação no local.

JURÍDICO – Paramétrico de custos

REGIONAL RMSP

PARAMÉTRICO DE CUSTOS JURÍDICO IMOBILIÁRIO

ABERTURA	$ FINAL	
Desdobro de IPTU	R$	2.500
Instituição de Condomínio	R$	79.387
Averbação da Construção	R$	492.023
Procuração Societária	R$	5.000
IPTU (Anual)	R$	35.339
Registro de Incorporação	R$	79.387
Honorário Incorporação	R$	-
Cópias e Autenticações	R$	5.000
Honorário Aquisição	R$	120.000
ITBI Terreno	R$	149.500
Registro de Escritura	R$	35.417
Total	**R$**	**1.003.552**
		R$ 2.011/uh

CRITÉRIOS DE INPUT DO SIMULADOR

Retificação: Em uma das laterais do lote a ser desmembrado tem uma diferença entre matrícula e real, ainda sendo avaliada a necessidade de retificação, mas seguindo o cenário mais conservador, o custo foi considerado

Parcelamento de solo: Estamos adquirindo parte de uma área maior e para essa divisão dos lotes acontecer o proprietário doará 5% de sua área maior ao município – **Obs.: nossa implantação e negociação já contempla a á**rea líquida, pós doações.

ITBI: 3,25% do valor a ser escriturado, de acordo com o código tributário vigente

CRONOGRAMA PRÉVIO

Cuiabinho	jun/25	jul/25	ago/25	set/25	out/25	nov/25	dez/25	jan/26	fev/26	mar/26	abr/26	mai/26	jun/26	jul/26	ago/26	set/26	out/26	nov/26	dez/26	jan/27	fev/27	mar/27	abr/27
	1	2	3	4	5	6	7	8	9	10	11	12	13	14	15	16	17	18	19	20	21	22	23
PROSPEC - Comitê Essencial																							
PROSPEC LEG DPP - Baixa LB / Reunião de Passagem																							
LEG - Emissão lei com ok para R4																							
LEG - Certidão de uso do solo																							
LEG - Diretriz Urbanística																							
NEG - Comitê Tenda Ampiado																							
LEG - Certidão de Conformidade																							
LEG - Manifesto Ambiental																							
LEG - Cadastro de Habitação - 20% das uh vendidas p/ lista																							
LINHA - PRE-KIT AP																							
LEG - Definição poligonal																							
LEG - PL e memo desmembramento																							
LEG - Desmembramento*																							
JUR - Registro desmembramento*																							
LINHA - Elaboração PL																							
LEG - Aprovação COMAER? Entender a necessidade																							
LEG - NBR																							
LEG - Aprovação Drenagem - entender a necessidade																							
LEG - Aprovação movimentação de terra - entender a necessidade																							
LEG - Aprovação supressão vegetação																							
NEG - Carta de enquadramento CEF																							
JUR - Isenção de ITBI ?																							
LEG - Alvara de aprovação e execução																							
LEG - Dispensa GRAPROHAB																							
JUR - Escritura e RI																							
CRE - Contratação CEF																							
NEG - Lançamento																							

- **DESCRIÇÃO DO IMÓVEL:** Matrícula nº 17 do Oficial de Registro de Imóveis de Itaquaquecetuba/SP ("Imóvel"), localizado na Estrada do Cuiabá, s/nº, Jardim Caiubi, Itaquaquecetuba/SP. Cadastro imobiliário nº 44434-32-76-0001-00-000

- **PROPRIETÁRIOS TABULARES:** APEMA – CONSULTORIA E EMPREENDIMENTOS LTDA ("APEMA").

- **CONSIDERAÇÕES JURÍDICAS SOBRE O IMÓVEL: (a) Retificação:** Foi realizado uma análise prévia pela Castro Topografia que orientou não ser necessário seguir com retificação de área desde que no processo de desdobro de área a ser aprovado perante prefeitura seja respeitado a descrição do imóvel conforme matrícula (se criar ângulos internos e medidas ou dividir as medidas existentes obrigatoriamente é necessário retificar área); **(b) Loteamento:** Providenciaremos as certidões do imóvel até a origem (transcrição) para verificarmos se o imóvel atual foi objeto de loteamento no passado e em caso positivo verificaremos eventuais restrições; **(c) Desmembramento:** O imóvel será objeto de desdobro, o qual uma área será adquirida pela Tenda e o remanescente ficará com o proprietário; **(d) Área construída:** Não há área construída registrada no imóvel, tampouco vinculada ao respectivo cadastro imobiliário. Assim, caso exista fisicamente alguma edificação no local, será necessário avaliar a eventual necessidade de regularização tanto perante a Prefeitura quanto junto ao Registro de Imóveis; **(e) Débitos Imobiliários**: A soma dos valores atualizados em 13/08/2024 perfaz o montante de R$ 22.804,89 (vinte e dois mil oitocentos e quatro reais e oitenta e nove centavos); **(g) Ônus e Gravames**: Consta sob o R-4 da matrícula do Imóvel, datado de 21/07/2011, que, por meio da escritura lavrada em 30/05/2011, pelo Tabelião de Notas de Itaquaquecetuba, arquivada no livro nº 170, fls. 060/063, a VENDEDORA deu o Imóvel em hipoteca 1º grau em favor da Prefeitura Municipal de Itaquaquecetuba, para garantia da execução das obras exigidas na implantação do loteamento, do qual o Imóvel não faz parte, denominado "Jardim Altos do Pinheirinho I", registrado em 12/04/2005 sob nº 10 na matrícula 31.848 do Oficial de Registro de Imóveis de Poá/SP. O cancelamento da hipoteca é condição resolutiva; **(h) Ocupação**: Imóvel desocupado; **(i) TAC**: Em conjunto com a equipe de legalização, até a lavratura da Escritura serão realizados estudos a fim de certificar a necessidade de assinatura de TAC ou eventual TAC assinado pelos proprietários e/ou antecessores; **(j) CONDEPHAAT, CONPRESP, IPHAN, Desapropriação e Melhoramentos:** Serão apurados em Due Diligence e **(l) Função Social da Propriedade:** O imóvel foi declarado pela vendedora que está livre e desimpedido de objetos e pessoas, logo não cumpre com a função social prevista na Constituição Federal, ou seja, fazer o uso diário do imóvel.

- **CONSIDERAÇÕES PRELIMINARES SOBRE OS PROPRIETÁRIOS (DD em andamento):**

- **A) APEMA – CONSULTORIA E EMPREENDIMENTOS LTDA.:**
  - Processos: Através da Certidão Estadual de Distribuições Cíveis do Tribunal de Justiça do Estado de São Paulo, foram localizados aproximadamente 540 processos em nome da proprietária tabular. Desta forma, solicitamos esclarecimentos a mesma, a qual apresentou relatório parcial constando que 181 processos estão extintos e arquivados. Aguardamos esclarecimentos adicionais para mensurar o passivo, além de apresentar o lastro patrimonial para garantia das obrigações.
  - CND Receita Federal – Certidão Positiva com efeito de Negativa.

- **CONCLUSÃO.:** A presente análise corresponde aos apontamentos em nome da proprietária tabular. De acordo com a DD prévia foram localizados aproximadamente 540 processos em nome da proprietária tabular dos quais 181 processos já foram esclarecidos, estando extintos e arquivados, desta forma, solicitamos esclarecimentos a mesma, para mensurar eventual o passivo, além de apresentar o lastro patrimonial para garantia das obrigações. Entendemos ser viável darmos andamento aos próximos atos a serem praticados para a efetiva aquisição do terreno a partir do momento em que obtivermos informações acerca dos processos, bem como na DD detalhada sobre a proprietária, antecessores e estudos jurídico e técnico do imóvel .

LEGALIZAÇÃO E DPP

➢ **ÁREA DE IMPLANTAÇÃO**

- O terreno é composto por 1 matrícula de nº 17 (1 ORI), em nome de pessoa jurídica (APEMA), totalizando área escriturária de 73.608,25 m² e real 69.122,20m² – diferença de área se encontra no terreno remanescente do vendedor.
- O cadastro do imóvel é urbano;

➢ **DIRETRIZ URBANÍSTICA**

- Será emitida após emissão de aprovação lei liberando maior quantidade de unidades habitacionais na categoria R4 no bairro Cuiabá.

LEGALIZAÇÃO E DPP

➢ **GRAPROHAB**

- Diretrizes SABESP 187/24, emitida em 08/11/24 para 499 UH
  - Esgoto – considerar condição 02 dispensando ETE, pois foi verificado que as obras do contrato 00.249./24 estão previstas para finalizar ainda em 2025, com ligação especial na rede cadastrada a estrada do Cuiabá.
  - Croqui disponibilizado não indica qual PV será interligado a rede de esgoto, deverá solicitar atualização de diretriz, após o término das obras da estrada do Cuiabá.
  - Possível FNA conforme identificado na diretriz de SABESP sobre rede de esgoto existente.
  - Água – ligação especial de água (derivação e VRP) considerando a interligação na rede existente na estrada do Cuiabá com diâmetro de 200mm na testada do lote.
- Verificar a necessidade da Dispensa em Graprohab junto ao cartório.

➢ **AVALIAÇÕES AMBIENTAIS**

Arbóreo

- Conforme análise, o terreno **não** é considerado como Patrimônio Ambiental
- Não incide sobre o terreno VPP;
- Incide sobre o Terreno Fragmento Florestal em estágio inicial de regeneração natural.
- Pelo cadastramento arbóreo constam 650 indivíduos isolados, sendo 639 exemplares se encontram no interior do imóvel e 11 exemplares na calçada.

Destes, 465 indivíduos são de origem nativa e117 são de origem exótica e 68 exemplares mortos ou cadastrados como tocos;

- Nenhum dos exemplares encontrados está na ameaçado de extinção;
- A propriedade não está inserida em Área de Patrimônio Ambiental (APA), Área de Proteção de Mananciais (APRM) e Unidade de Conservação;
- Conforme orientação de prospecção, o cenário considera a supressão de 540 exemplares localizados no interior do lote, com compensação de 1898 exemplares.

LEGALIZAÇÃO E DPP

Hidrografia

- O Imóvel apresenta corpos d'água internos ao perímetro ou próximo;
- Córrego mais próximo do imóvel, sendo este o Córrego Cuiabá

➢ **COMAER**

- Não apresentado.

➢ **AVALIAÇÕES AMBIENTAIS**

Contaminação (Não Contaminado)

1- Informe de levantamento inicial:
Existência de PV de esgoto da SABESP lindeiro ao imóvel.
O Estudo Preliminar será analisado para a necessidade de continuação para uma Análise confirmatória, pois não há indícios contaminação.

Cabe ressaltar que a Cuiabá (armazém/loja de materiais de construção) se encontra a jusante, podendo ser de menor interesse para a investigação preliminar.

Meios:

1- Água: Contaminado: Não

2- Solo: Contaminado: Não

3- Gás: Contaminado: Não

LEGALIZAÇÃO E DPP

➢ **ÓRGÃOS DE PATRIMÔNIO HISTÓRICO**

- Municipal – Não apresentado.
- Estadual – Condephaat: Não apresentado.
- Federal – IPHAN: Não apresentado.

➢ **ABASTECIMENTO SANITÁRIO**

- Diretrizes SABESP 187/24, emitida em 08/11/24 para 499 UH
  - Esgoto – considerar condição 02 dispensando ETE, pois foi verificado que as obras do contrato 00.249./24 estão previstas para finalizar ainda em 2025, com ligação especial na rede cadastrada a estrada do Cuiabá.
  - Croqui disponibilizado não indica qual PV será interligado a rede de esgoto, deverá solicitar atualização de diretriz, após o término das obras da estrada do Cuiabá.
  - Possível FNA conforme identificado na diretriz de SABESP sobre rede de esgoto existente – na área remanescente do proprietário.
  - Água – ligação especial de água (derivação e VRP) considerando a interligação na rede existente na estrada do Cuiabá com diâmetro de 200mm na testada do lote.

➢ **DRENAGEM**

- Lançamento da drenagem no Córrego Cuiabá;
- Desenvolvido estudo hidrogeológico para identificar corpos d'água dentro do terreno.
- Desenvolvido estudo hidrológico prevendo cota de inundação próximo ao córrego 749,269 e no canal de drenagem 749,775.

LEGALIZAÇÃO E DPP

- **URBANIZAÇÃO**
- Aguardar emissão de diretriz urbanística para entender a necessidade de melhoramento viário.

- **CONTRAPARTIDA**
- Haverá cobrança de medida mitigadora, em conversa com Secretário, considerar 400mil.

- **MOVIMENTAÇÃO DE TERRA**
- Entender a necessidade de aprovação de projeto de movimentação de terra junto ao município.

- **OUTROS ITENS NECESSÁRIOS/ESPECÍFICOS**
- Será necessário projeto de desmembramento
- Logística solicita que seja obtido autorização para utilização do viário.

Obrigado