Tenda

sua próxima conquista

Book de Investimento - Comitê Ampliado

Regional: SP – Zona Norte

Projeto: Monte Trindade

Data Comitê: 26.06.25

Nome	Monte Trindade - Investimento	Observação - Monte Trindade
Fabricio Quesiti Arrivabene	Aprovado	ok
Alexandre Regis de Oliveira	Aprovado	ok
Amanda da Silva Bezerra	Aprovado	ok
Alejandro Octavio Abiusi	Aprovado	ok
Rodrigo Osmo	Aprovado	N/A
Renan Barbosa Sanches	Discutir em Comitê	1) o prazo de obra total me pareceu muito alto. Qual o prazo de pre e pos forma considerado e suas justificativas? 2) na 1a pagina indicamos como "comite ampliado" mas no one page falamos de "comite essencial". pfv confirmar do que se trata e ajustar se for o caso
Luiz Mauricio de Garcia Paula	Discutir em Comitê	o que mudou com relação as diretrizes internas da Sabesp que agora viabilizaria o projeto?
Andre Luis Menegazzo Padilha	Aprovado	Ok

1. Perguntas Renan Barbosa Sanches

(i) O prazo de obras total me pareceu muito alto. Qual o prazo de pre e pos forma considerado e suas justificativas?

(Getec) R: O terreno em questão apresenta uma complexidade para a execução da obra. Estamos considerando sete meses de prazo de pré-forma, devido as seguintes complexidades deste terreno:

a) Necessidade de recalque de toda a drenagem provisória durante a fase de construção, bem como ao recalque da drenagem definitiva da área dos taludes após a conclusão da obra, para viabilizar a operação do condomínio. Em função disso, o projeto prevê a construção de um tanque de recalque, posicionado no ponto mais baixo do terreno, de forma a garantir a eficiência do sistema. Considerando que não há garantia de que o início da obra ocorrerá em período seco e, com base no histórico de problemas com a vizinhança enfrentados no empreendimento Mirante Pirituba, que apresenta características técnicas similares, entendemos ser necessário prever um prazo adicional de um mês para construção de tanque de recalque no período de pré-forma.
Atualmente existe um tanque de recalque e um sistema de bombeamento situado no ponto mais baixo do terreno executado pelo próprio proprietário, com o objetivo de atender o recalque das águas das chuvas. No entanto, ainda não foi possível assegurar que esse sistema poderá atender o período de obras. No decorrer do desenvolvimento do projeto analisaremos com mais detalhes a possibilidade de utilizá-lo, podendo haver uma pequena redução do prazo pré-forma.
Também está em negociação com o vizinho a jusante a possibilidade de servidão de passagem para eliminarmos a necessidade de recalque definitivo da drenagem.

b) Considerando que a implantação conta com a maior lâmina de torre (20PP), a execução do lajão, que é caminho crítico é maior que média dos outros empreendimentos, gerando um acréscimo de prazo de um mês. Adicionalmente, em relação à fase de pós-forma, o prazo total estimado é de dez meses, sendo oito meses conforme estabelecido no plano BP25, acrescidos de dois meses adicionais devido às exigências específicas relacionadas à instalação do transformador pedestal ("pad mounted"). Esse tipo de transformador é necessário em razão do número de unidades do empreendimento e está sujeito a um processo de aprovação mais complexo e demorado junto à concessionária ENEL.

1. Perguntas Renan Barbosa Sanches

(i) Na 1ª pagina indicamos como “comitê ampliado” mas no one page falamos em “comitê essencial”. Pfv confirmar do que se trata e ajustar se for o caso;

(Prospec) R: O correto é “Comitê Ampliado” sendo considerado 100% das unidades para BSC (751uh). Material ajustado

1. Perguntas Luiz Mauricio de Garcia Paula

(i) O que mudou com relação as diretrizes internas da Sabesp que agora viabilizaria o projeto?

R; A diretriz de 08/22 indicava uma extensão complexa, atravessando um terreno particular. O custo estimado (base 08/22) estava em +-10.000/uh e quase 2km de extensão. A justificativa dada pela Sabesp, era que a cidade vizinha Cajamar estava com problemas no tratamento da água, e como medida paliativa, direcionaram toda capacidade de água da região do Monte Trindade para abastecer Cajamar. Diante disso, a região não tinha capacidade para suportar o empreendimento. Mantivemos contatos recorrentes com a Sabesp para atualizações, e sempre informaram que estariam executando obras na rede, porém não conseguiam precisar quando. Caso a Tenda necessitasse a antecipação, seria responsável pela execução. Mantivemos o terreno em stand-by pois a execução além de impactar financeiramente, era de grande complexidade e riscos relevantes. Com a privatização, a extensão desse trecho entrou no plano e na lista de prioridades de execução da Sabesp, e houve a atualização da diretriz reduzindo a parte de nossa obra de extensão, viabilizando o empreendimento.

Diretriz 08/22

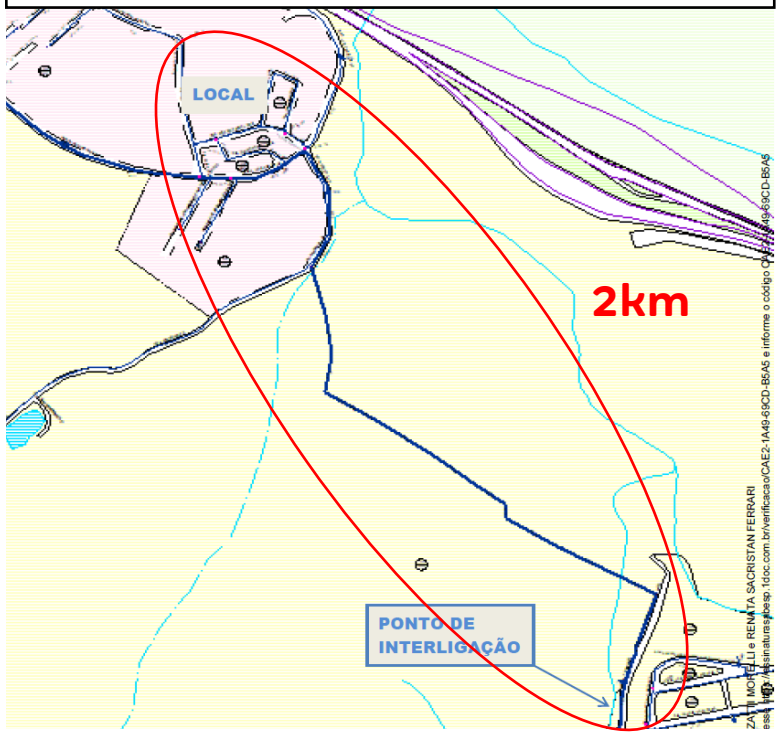

Diretriz 06/25

One Page – Monte Trindade

Cidade	São Paulo	**Mancha de demanda**	SP - SZN2 - São Paulo Norte 2
Regional	SP	**Cluster MPR**	1 - Vermelho
Cenário de Aprovação	Aprovação	**Tipo de Aprovação**	Consolidado
Fase Anterior	N/A		
Tipo de Comitê	Investimento	**Versão da VF**	Versão 1.0: Jun

Unidades (% Vagas)	751 (4%)	**CA Máx | Proj**	4,1 | 2,4
Tipologia	F2E - Concreto	**Escritura**	jan-27
Fases	1 fases	**Lçto | Duração (m)**	mar/27 | 31

Valor Líquido do Terreno (% VGV)	13.466 (8,2%)	**Un. Perm. Fís (% Ter)**	0 (0,0%)
Cash (Correção)	0 (N/A)	**%VGV Perm Fin Líquida (% Ter)**	8,2% (100,0%)
Valor R$/m²	1.507	**VAR (%VGV)**	000 (0,0%)

Custo Construção (%VGV)	75.957 (46,2%)	**Indireto Unit.**	17.828
Prazo da Obra (meses)	25	**Torre Unit.**	53.510
Custo Total Unit. | Corrigido (LPU):	101.141 | 100.558 (92)	**Infra Unit.**	14.356
Início de Obra	set-27	**Fundação Unit.**	7.628

Preço Nominal Unit.	218.929	**VSO**	42
Preço Raso Unit.	202.044	**Referência**	Vision
Avaliação Unit.	220.746	**Renda (% em RET 1%)**	2.796 (48,1%)

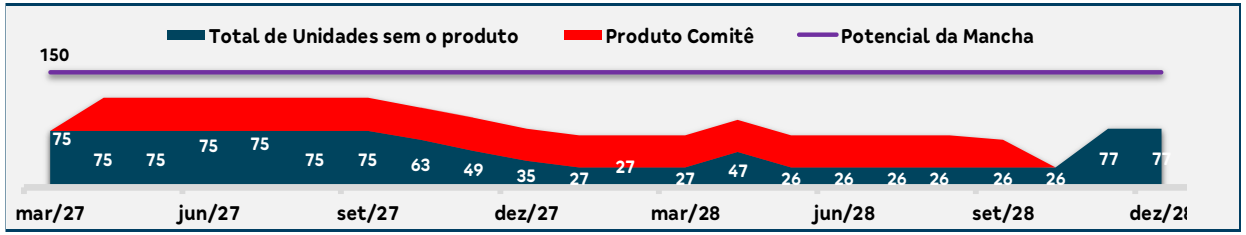

LI (Régua):	**20,5% (20,0%)**	**Margem Bruta Econômica:**	36,2%
LI Resiliência:	14,5% (N/A)	**Margem Rasa Econômica:**	30,2%
Margem Bruta REF:	39,1%	**Margem Contribuição Econômica:**	25,6%
Margem Rasa REF:	**34,1%**	**Exposição (% VGV):**	12.522 (7,0%)
TIR:	175,2%	**VGV Total:**	164.416
Payback Contingente (21 m) :	**19 m/ (-2 m)**	**Ger. Caixa 12 meses (R$):**	-
Payback Consolidado:	19	**Ger. Caixa 24 meses (R$):**	(3.124)

Destaques

[1] O Terreno está localizado na Rua Eneas Camargo – Chácara Maria Trindade, mancha ZN2 - Zona Norte de São Paulo. Região de borda, lindeiro ao empreendimento já entregue Solares. Terreno com gabarito T+9 e com área de 10.000 m², viabilizado em condomínio e fase única.

[2] Terreno com gabarito T+9 e com área de 10.000 m², viabilizado em condomínio e fase única; composto por 1 condomínio e um total de 751uh, 28 vagas de carro e 10 vagas de moto. CA do projeto está em 2,38x , sendo CA máx 4,05x.

[3] Condição Comercial: 100% Permuta Financeira

- 100% Permuta Financeira -> 9% de permuta bruta com desconto de 9%, resultando em uma permuta líquida de 8,2%, estimativa na viabilidade em 13,4MM (valor liquido)
- O contrato indica uma estimativa de 10,2MM porém sem compromisso ou obrigação além da permuta bruta de 9%, sem preço mínimo garantido, sem condição de correção e sem prazo para quitação.
- **OBS:** Aproximadamente R$ 563/CA e R$ 1.340/m2 (base valor terreno liquido na viabilidade 13,4MM)

[4] Condições Resolutivas:

a) Etapa I: Em até 5 (cinco) meses para resolutivas técnicas, resolutivas jurídicas e financeira; Etapa Etapa II: 24 meses após a superação da Etapa I para aprovação de projeto, contratação CEF, análise técnica, financeira e comercial para o lançamento do empreendimento;

b) A critério da Tenda podemos suspender o contrato pelo prazo que for necessário, suspendo as obrigações de pagamento e lavratura da escritura;

[5] Projeto para aprovação no formato de **Comitê Ampliado**;

[6] Terreno assinado em ago/22, e em virtude da inviabilidade técnica de abastecimento de água da região pela Sabesp, o CVC ficou suspenso até a presente data. Com a privatização da Sabesp e novas diretrizes internas da concessionária, nos últimos dias recebemos diretriz atualizada com viabilidade e pequena extensão.

Pareceres

Análise da Mancha e Implantação

Prospecção

Operações

Inteligência de Mercado

Financeiro

Anexos

Pareceres

Área	Riscos Associados	Parecer	Criticidade
Jurídico	Observadas as ressalvas e desde que implementadas as recomendações formuladas ao longo do parecer jurídico, inclusive sobre os mecanismos para a responsabilidade ambiental recair unicamente ao Vendedor, a serem estabelecidas em aditamento, entendemos que não existem óbices e/ou elementos jurídicos intransponíveis capazes de impedir ou colocar em risco a aquisição pretendida.	Ok com ressalvas	
Legalização	Não há risco	Ok	
Produto	N/A	Ok	
GETEC	Não foi considerado nenhum sistema extravasor para o tanque de recalque de drenagem	Ok com ressalvas	
Logística	N/A	Ok	
Prospecção	Projeto de borda, ao lado do empreendimento Solares. Renegociação em andamento reduzindo a fração do terreno para maximizar os resultados financeiros. Negociação em andamento com o vizinho a jusante para instituição de servidão de passagem para eliminar o sistema de recalque das águas pluviais dos taludes e sair por gravidade. Toda área de implantação do empreendimento já está saíndo por gravidade pela testada do terreno	Ok	
Inteligência de mercado	IM avalia o Preço Vision como factível	Ok	
Comercial/Ciclo	O Ciclo considerou o Preço e o VSO como viáveis. O projeto está localizado na rua em que lançamos o Solares Nascente e Ponte, sucesso de vendas, região em desenvolvimento, próximo à cidade de Polvilho e sem concorrência.	Ok	
Estudos Econômicos	Sem riscos associados.	Ok	

Pareceres

Análise da Mancha e Implantação

Prospecção

Operações

Inteligência de Mercado

Financeiro

Anexos

Localização – Rua Enéas Camargo, 11 – Chácara Maria Trindade – São Paulo - SP

Hospital municipal

Supermercado Paraíso

Pesqueiro Novo Anhanguera

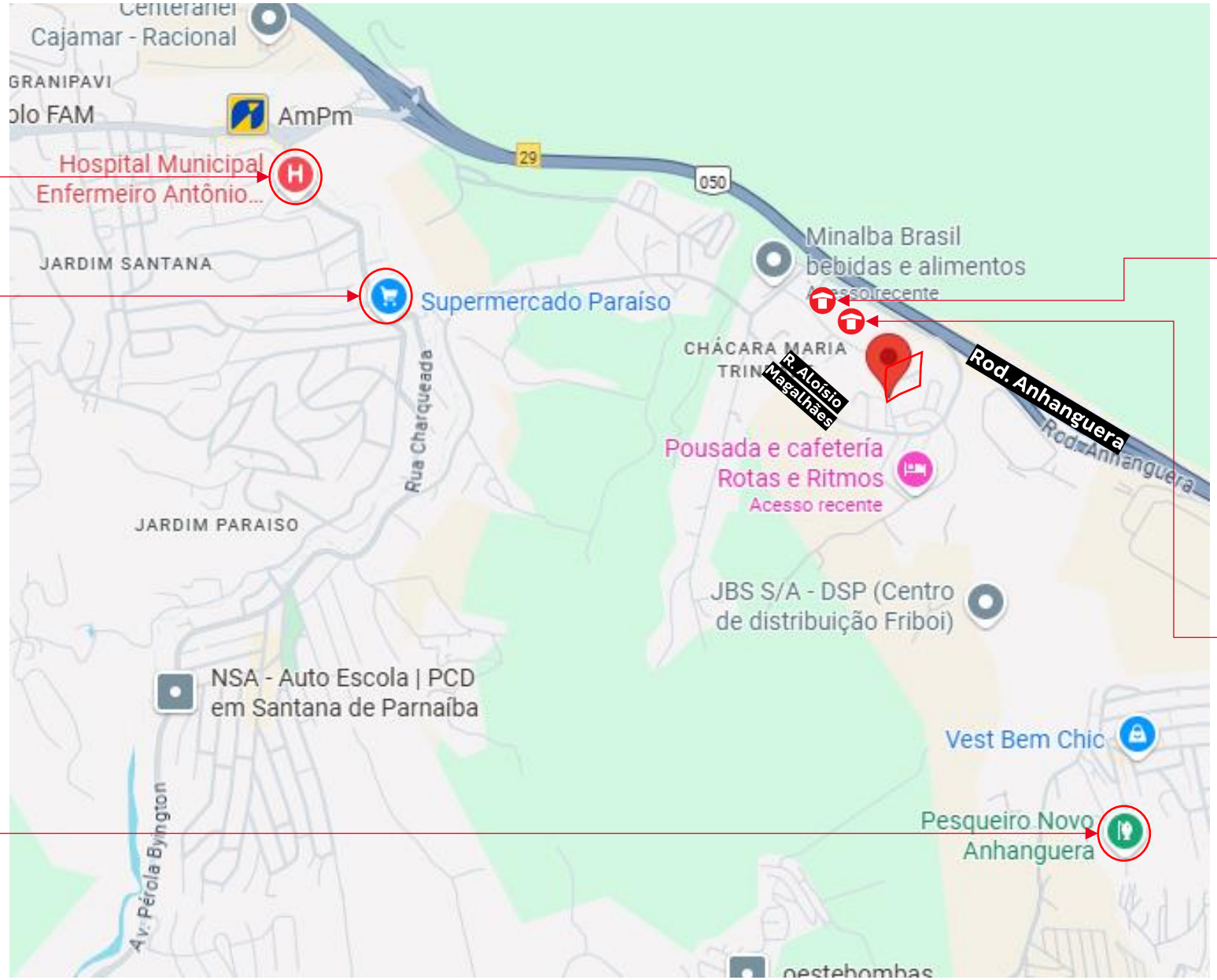

Tenda - Solares Nascente

Tenda - Solares Poente

Localização – Rua Enéas Camargo, 11 – Chácara Maria Trindade – São Paulo - SP

Mancha de Demanda

MANCHAS DE DEMANDA

• SZN – São Paulo Norte

Lançamento

1. Viva City Jaraguá
2. Viva Limão | Parque Limão
3. Melodia Jaçanã
4. Farol Cantareira
5. Reserva Jaraguá

LandBank

6. Horizonte Jaraguá
7. Chácara Pirituba
8. Nilo Cairo
9. Bela Vista Jaraguá
10. Monte Trindade
11. Travessa Igarapé

Cluster MPR – (Comitê)

Cluster 1 - Vermelho

Região

Borda

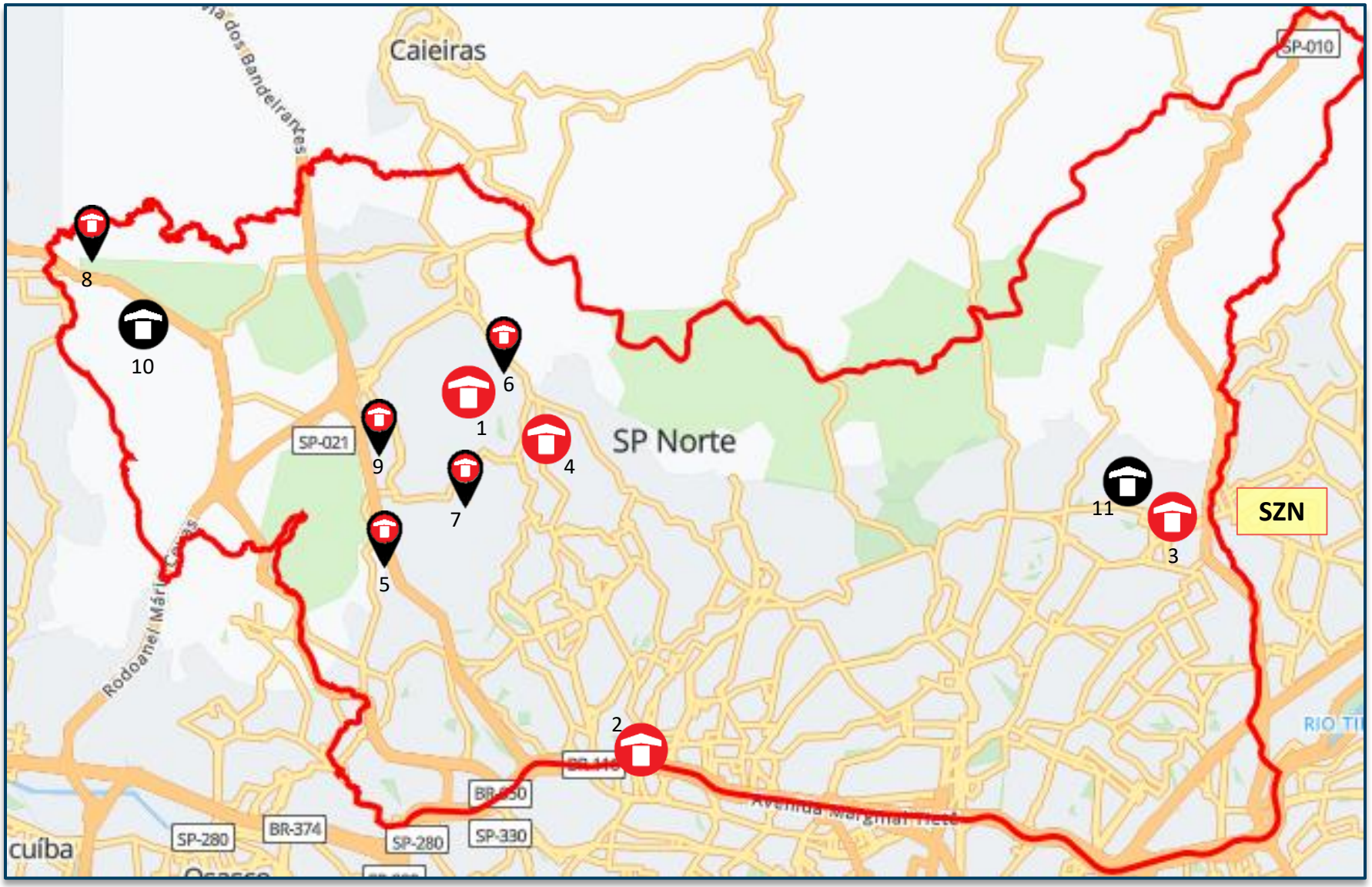

Lançados *LandBank* *Comitê*

PRODUTO

Empreendimento Eneas Camargo Investimento

Informações Gerais – Condomínio Único			
Terreno	Área terreno real	10.000,00m²	
	Menor poligonal	10.000,00m²	
	APP/FNA	754,62	
	Reserva de calçada/ melhoramento víario	180,44	
	Área liquida	9.819,56m²	
	Zoneamento	ZPI-2	
	Ca máximo	4,05	ZONA: 2,25
			INCENTIVO HIS 1: 1,125
			INCENTIVO COTA: 0,675
	Ca projetado	2,38 (Líquido: 2,42)	
	Gabarito máximo	28,00m (T+9)	
Geral	Total uh	751	
	Total de vagas	28 vagas de carro | 10 motos | 1 PCD | 1 Idoso| 02 vagas externas	
Tipologia	Tipologia	SP 0200 CDW	
	Gabarito	T+9	
	Lâmina	2x 18PP | 2x 20PP	
	Área privativa	31,82m²	
Condomínio	Unidade pcd	23 (cobertura)	
	Unidade lazer| lazer e técnica	05 | 04	
	Torres	04	
	Fases	01	
Lazer	Lazer coberto	Churrasqueiras, Salão de Festas externo e interno, Brinquedoteca, Fitness, Espaço Office, Espaço Teen, Espaço Saúde, Espaço Oficina.	
	Lazer descoberto	Play baby, Play kids Fitness Externo e Praça de chegada	

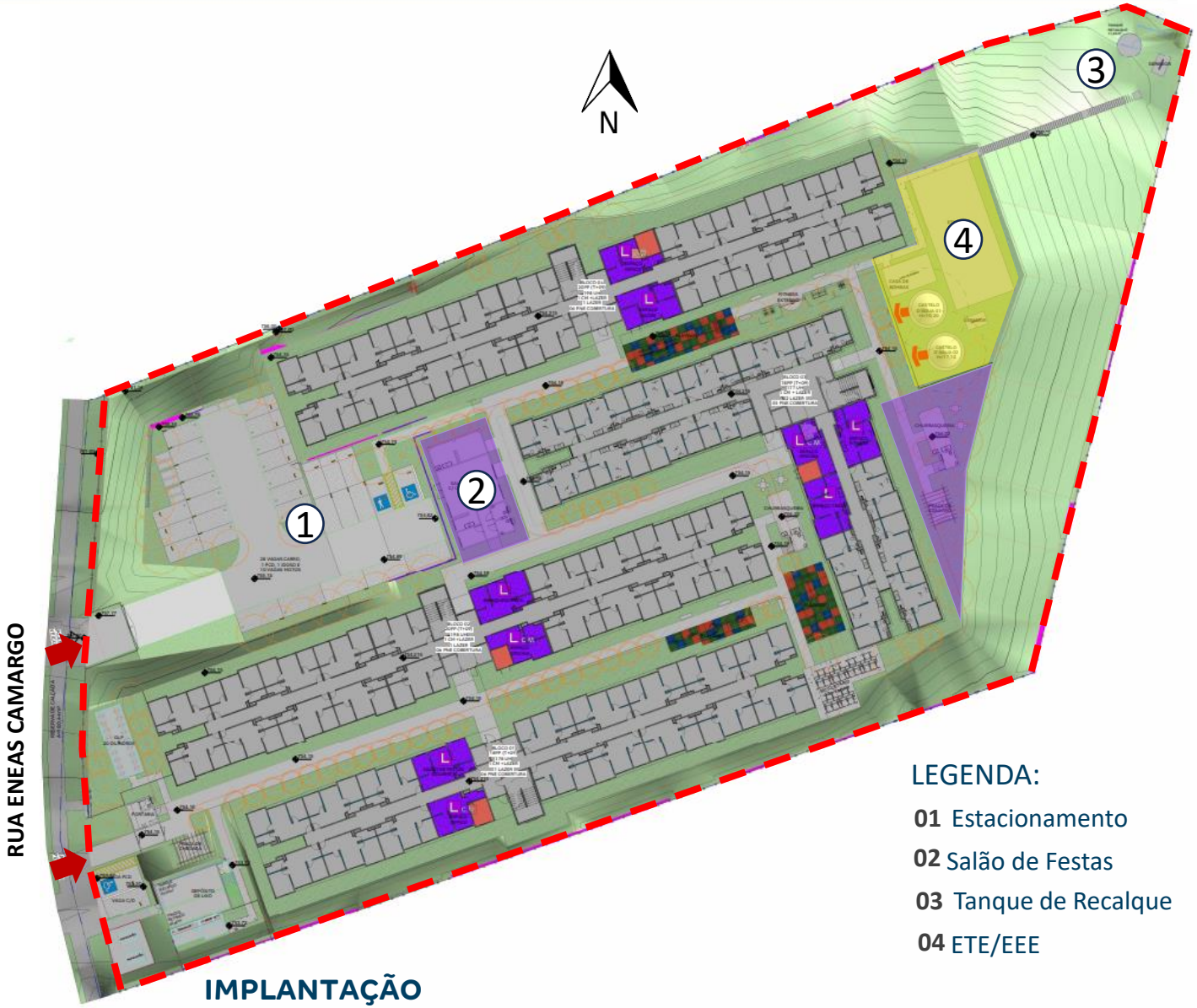

IMPLANTAÇÃO

LEGENDA:

01 Estacionamento

02 Salão de Festas

03 Tanque de Recalque

04 ETE/EEE

PRODUTO

Empreendimento Eneas Camargo Investimento

	Descrição	Criticidade	Parecer
Usabilidade	Acesso Empreendimento		
	Percurso do pedestre até torre		
Diferencial produto	Prime	Não	
	Supercondomínio	Não	
	Atributos Infra	Não	
	Atributos Torre	Não	
	Edifício Garagem	Não	

	Riscos associados	Parecer	Criticidade
Produto	Recalque parcial de drenagem, para drenar área de talude	Ok	

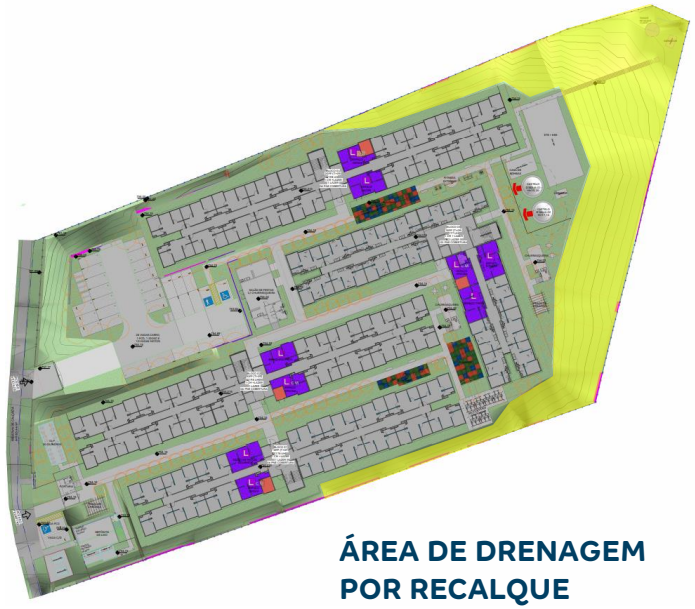

ÁREA DE DRENAGEM POR RECALQUE

IMPLANTAÇÃO

Pareceres

Análise da Mancha e Implantação

Prospecção

Operações

Inteligência de Mercado

Financeiro

Anexos

Condições do Negócio

- VALOR DO NEGÓCIO
- R$ 10.200.000,00 (valor contratual estimado)

- CONDIÇÃO COMERCIAL
- 100% Permuta Financeira -> 9% de permuta bruta com desconto de 9%, resultando em uma permuta líquida de 8,2%, estimativa na viabilidade em 13,4MM (valor liquido)
- O contrato indica uma estimativa de 10,2MM porém sem compromisso ou obrigação além da permuta bruta de 9%, sem preço mínimo garantido, sem condição de correção e sem prazo para quitação.
- OBS: Aproximadamente R$ 563/CA e R$ 1.340/m2 (base valor terreno liquido na viabilidade 13,4MM)

- PREVISÃO EM CONTRATO DE DESCONTOS DO PREÇO
- 1) Eventual descontaminação sobre o imóvel; 2) Despesas para plantio de árvores e cumprimento do Termo de Ajuste de Conduta (TAC) referente ao crime ambiental cometido pelo vendedor (supressão irregular de árvores)

- PRAZOS CONTRATUAIS
- Etapa I: Prazo 05 meses para resolutivas técnica, jurídica e renovação do alvará de vendas pelo prazo de 22 meses em igualdade com o prazo descrito em CVC; (previsão ago/25)
- Etapa II: Em até 24 meses após a superação da Etapa I para aprovação de projeto, contratação CEF, análise técnica, financeira e comercial para o lançamento do empreendimento (previsão CVC ago/27 + prorrogações à critério da Tenda/ previsão Leg jan/27);
- Conforme cláusula 6.2 do CVC assinado podemos suspender os prazos contratuais mediante envio de comunicação por escrito em caso de não superação de qualquer condição resolutiva à critério da Tenda pelo prazo que for necessário, suspendo as obrigações de pagamento e lavratura da escritura;

- GARANTIAS
- Escritura de novação e confissão de divida;

- CORRETAGEM
- R$ 612.000,00 em 6 parcelas mensais, iguais, consecutivas e reajustáveis pelo IPCA a partir da superação da primeira etapa de resolutivas, sendo que a primeira parcela será contra a lavratura da EVC;

Condições do Negócio

➢ RESOLUTIVAS DO CONTRATO

I - Em até 5 (cinco) meses a contar da assinatura do presente instrumento (previsão ago/25):

i. a existência de ação de desapropriação e/ou declaração de utilidade pública que objetive o Imóvel ou parte dele;
ii. a existência de cadastro como imóvel tombado e/ou em processo de tombamento e/ou em áreas envoltórias, no IPHAN, CONDEPHAAT ou CONPRESP, que impossibilitem a adequada consecução do Empreendimento Imobiliário;
iii. a não apresentação satisfatória da documentação e/ou esclarecimentos indicados nas Cláusulas 3.1.1, 3.2, 3.2.1 e 3.4 e no ANEXO I pela VENDEDORA no prazo ali indicado ou a existência de qualquer apontamento nos documentos e certidões forenses que objetive, onere e/ou possa trazer vício à cadeia dominial do Imóvel e/ou possam reduzir a VENDEDORA ao estado de insolvência civil, ou que traga insegurança jurídica na operação objeto deste instrumento, a exclusivo critério da COMPRADORA;
iv. a impossibilidade da realização do estudo de passivo ambiental ou a existência de qualquer tipo de contaminação do solo, subsolo e águas do Imóvel, bem como qualquer outro tipo de passivo ambiental e/ou impossibilidade de remoção de árvores que comprometam o Empreendimento que a COMPRADORA pretende desenvolver no Imóvel;
v. a existência de óbice à consecução, no Imóvel, do Empreendimento imobiliário almejado pela COMPRADORA;
vi. a não viabilidade das redes de água e esgoto existentes no local, que sejam tidas como insuficientes a garantir a vazão necessária às unidades autônomas que comporão o Empreendimento pretendido;
vii. a não viabilidade de rede elétrica para abastecimento do futuro Empreendimento;
viii. o não aperfeiçoamento de uma ou mais condições resolutivas, relativas ao terreno e ao Empreendimento, abaixo relacionadas:
    i. Análise da viabilidade técnica e financeira do Empreendimento;
    ii. Análise da viabilidade comercial do Empreendimento;
    iii. Apuração de condições técnica e eventualmente impeditivas do Imóvel
    iv. Análise jurídica da documentação do terreno e de antecessores.
ix. caso o gabarito de altura pretendido para o Empreendimento pretendido não seja aprovado no DECEA (Departamento de Controle do Espaço Aéreo) e COMAER (Comando da Aeronáutica);
x. Caso o presente negócio não seja aprovado pelo Comitê de Investimentos da COMPRADORA;

Condições do Negócio

➢ RESOLUTIVAS DO CONTRATO

II – Em até 24 (vinte e quatro) meses a contar da superação das condições descritas no item "I", supra (previsão CVC ago/27 + prorrogações à critério da Tenda/ previsão Leg jan/27);

i. a alteração do cenário macroeconômico que modifique os indicadores estabelecidos na viabilidade financeira do projeto e que, a critério da COMPRADORA, acarretem a inviabilidade técnica, financeira e comercial anteriormente verificada para o Empreendimento;
ii. a não aprovação nos termos da legislação vigente do projeto do Empreendimento junto à Prefeitura Municipal e demais órgãos competentes,necessários para viabilizar sua edificação, bem como que em tal aprovação não sejam incluídas exigências, pela Municipalidade, que acarretem obrigações adicionais, tais como, exemplificativamente, outorga onerosa, potencial construtivo, a imposição de contrapartida onerosa;
iii. (xiii) a inviabilidade de contratação de financiamento pela instituição financeira para construção do Empreendimento, consoante os termos e condições do Programa do Governo Federal Casa Verde e Amarela (PCVA), ou qualquer outro programa que venha a substituí-lo, inclusive por força da alteração do cenário jurídico constatado no âmbito da auditoria jurídica anteriormente realizada, a ser novamente verificado por meio da análise dos documentos e certidões em nome da VENDEDORA e do Imóvel atualizados com 30 (trinta) dias de antecedência para a outorga da escritura de compra e venda do Imóvel, nos termos da cláusula 3.5, supra;

Pareceres

Análise da Mancha e Implantação

Prospecção

Operações

Inteligência de Mercado

Financeiro

Anexos

Custo de Construção

	ENEAS CAMARGO II CEN. 02 | R03	ENEAS CAMARGO II CEN. 02 | R02	MARIANA CEN. 06 | R08	ESSÊNCIA DO CAMPO CEN. 04 | R06 CONSOLIDADO
Torres	4	4	3	6
Unidades Construídas	760	760	600	960
Unidades Vendidas	751	751	592	550 | 396
Total Unidades Vendidas	751	751	592	946
Condomínios (qta.)	1	1	1	1
Cidade	São Paulo - SP	São Paulo - SP	São Paulo - SP	São Paulo - SP
Produto / Selo	F2E - V0200 CDW	F2E - V0200 CDW	F2E - V0200 CDW	F2E - V0200 CDW
Varanda	-	-	180	216
Tipologia	1 Torre | T+09 | 18PP	1 Torre | T+09 | 18PP	3 Torres | T+09 | 20PP	4 Torres | T+09 | 14PP
Tipologia	1 Torre L | T+09 | 18PP	1 Torre L | T+09 | 18PP	-	2 Torres | T+09 | 20PP
Tipologia	2 Torres | T+09 | 20PP	2 Torres | T+09 | 20PP	-	-
Projeto Infra	AP	AP	AP	AP
Projeto Torre	AP / EM	AP / EM	AP	AP
Mês Base	junho-25	junho-25	abril-25	outubro-25
Incc	1.191,327	1.184,462	1.178,386	1.141,398
LVS	abril-25	março-25	março-25	setembro-24
Indiretos	abril-25	março-25	março-25	setembro-24
Base de Preço	LPU 92	LPU 90	LPU 89	LPU 83
Takt	2x2	2x2	2X2	2x2
Prazo (mês)	25	25	24	20 | 18
CUSTO TOTAL I	R$ / UND R$ 99.914	R$ / UND R$ 99.385	R$ / UND R$ 101.226	R$ / UND R$ 93.319
Indireto	R$ 17.828	R$ 18.161	R$ 18.868	R$ 20.396
Torre	R$ 53.510	R$ 52.666	R$ 55.341	R$ 52.679
Infra	R$ 14.356	R$ 14.339	R$ 13.167	R$ 11.752
Fundação	R$ 7.628	R$ 7.657	R$ 9.813	R$ 6.422
EEE	R$ 508	R$ 508		
ETE	R$ 1.843	R$ 1.843		
Contenção	R$ 2.258	R$ 2.228	R$ 741	R$ 701
Terraplenagem	R$ 1.983	R$ 1.983	R$ 3.296	R$ 1.369
CUSTO TOTAL II	R$ 1.227	R$ 257	R$ 1.462	R$ 1.488
Urbanização	R$ 98	R$ 97	R$ 329	R$ 371
Drenagem			R$ 76	R$ 60
Extensão de Rede Elétrica	R$ 160	R$ 160	R$ 405	R$ 127
Extensão de Rede Hidráulica	R$ 970	Não Considerado	R$ 651	R$ 930
CUSTO TOTAL III				
Incorridos				
CUSTO TOTAL IV				
Ed. Garagem				
CUSTO TOTAL V		R$ 578	R$ 1.128	R$ 4.147
Atualização por INCC		R$ 578	R$ 1.128	R$ 4.147
CUSTO TOTAL I+II	R$ 101.141	R$ 99.642	R$ 102.689	R$ 94.807
CUSTO TOTAL I AO IV	R$ 101.141	R$ 100.220	R$ 103.816	R$ 98.954

Custo de Construção

	ENEAS CAMARGO II CEN. 02 | R03	ENEAS CAMARGO II CEN. 02 | R02	
Torres	4	4	
Unidades Construídas	760	760	
Unidades Vendidas	751	751	
Total Unidades Vendidas	751	751	
Condomínios (qta.)	1	1	
Cidade	São Paulo - SP	São Paulo - SP	
Produto / Selo	F2E - V0200 CDW	F2E - V0200 CDW	
Varanda	-	-	
Tipologia	1 Torre | T+09 | 18PP	1 Torre | T+09 | 18PP	
Tipologia	1 Torre L | T+09 | 18PP	1 Torre L | T+09 | 18PP	
Tipologia	2 Torres | T+09 | 20PP	2 Torres | T+09 | 20PP	
Projeto Infra	AP	AP	
Projeto Torre	AP / EM	AP / EM	
Mês Base	junho-25	junho-25	
Incc	1191,33	1184,46	
LVS	abril-25	março-25	
Indiretos	abril-25	março-25	
Base de Preço	LPU 92	LPU 90	
Takt	2x2	2x2	
Prazo (mês)	25	25	
CUSTO TOTAL I	R$ / UND R$ 99.914	R$ / UND R$ 99.385	DIF R$ 529
Indireto	R$ 17.828	R$ 18.161	-R$ 333
Torre	R$ 53.510	R$ 52.666	R$ 844
Infra	R$ 14.356	R$ 14.339	R$ 17
Fundação	R$ 7.628	R$ 7.657	-R$ 29
EEE	R$ 508	R$ 508	R$ 0
ETE	R$ 1.843	R$ 1.843	R$ 0
Contenção	R$ 2.258	R$ 2.228	R$ 30
Terraplenagem	R$ 1.983	R$ 1.983	R$ 0
CUSTO TOTAL II	R$ 1.227	R$ 257	R$ 970
Urbanização	R$ 98	R$ 97	R$ 0
Drenagem	R$ 0	R$ 0	R$ 0
Extensão de Rede Elétrica	R$ 160	R$ 160	R$ 0
Extensão de Rede Hidráulica	R$ 970	Não Considerado	R$ 970
CUSTO TOTAL III	R$ 0	R$ 0	R$ 0
Incorridos	R$ 0	R$ 0	R$ 0
CUSTO TOTAL IV	R$ 0	R$ 0	R$ 0
Aprendizado	R$ 0	R$ 0	R$ 0
CUSTO TOTAL V	R$ 0	R$ 578	-R$ 578
Atualização por INCC	R$ 0	R$ 578	-R$ 578
CUSTO TOTAL	R$ 101.141	R$ 100.220	R$ 921

INDIRETOS
-313 | G11 – Serviços Técnicos

TORRE
+720 | Aço (Ajuste taxa de aço e atualização de preço)
R03: 54,93Kg/m³ | R$6,53/Kg
R02: 43,50Kg/m³ | R$6,43/Kg
+121 | Concreto (Preço)

EXTENSÃO DE REDE
+970 | 168m de rede de água (Anteriormente não havia diretriz)

Custo de Construção

	ENEAS CAMARGO II CEN. 02 | R03	MARIANA CEN. 06 | R08	
Torres	4	3	
Unidades Construídas	760	600	
Unidades Vendidas	751	592	
Total Unidades Vendidas	751	592	
Condomínios (qta.)	1	1	
Cidade	São Paulo - SP	São Paulo - SP	
Produto / Selo	F2E - V0200 CDW	F2E - V0200 CDW	
Varanda	-	180	
Tipologia	1 Torre | T+09 | 18PP	3 Torres | T+09 | 20PP	
Tipologia	1 Torre L | T+09 | 18PP	-	
Tipologia	2 Torres | T+09 | 20PP	-	
Projeto Infra	AP	AP	
Projeto Torre	AP / EM	AP	
Mês Base	junho-25	abril-25	
Incc	1191,33	1178,39	
LVS	abril-25	março-25	
Indiretos	abril-25	março-25	
Base de Preço	LPU 92	LPU 89	
Takt	2x2	2X2	
Prazo (mês)	25	24	
CUSTO TOTAL I	R$ / UND R$ 99.914	R$ / UND R$ 101.226	DIF -R$ 1.313
Indireto	R$ 17.828	R$ 18.868	-R$ 1.040
Torre	R$ 53.510	R$ 55.341	-R$ 1.831
Infra	R$ 14.356	R$ 13.167	**R$ 1.189**
Fundação	R$ 7.628	R$ 9.813	-R$ 2.186
EEE	R$ 508	R$ 0	**R$ 508**
ETE	R$ 1.843	R$ 0	**R$ 1.843**
Contenção	R$ 2.258	R$ 741	**R$ 1.517**
Terraplenagem	R$ 1.983	R$ 3.296	-R$ 1.312
CUSTO TOTAL II	R$ 1.227	R$ 1.462	-R$ 235
Urbanização	R$ 98	R$ 329	-R$ 232
Drenagem	R$ 0	R$ 76	-R$ 76
Extensão de Rede Elétrica	R$ 160	R$ 405	-R$ 246
Extensão de Rede Hidráulica	R$ 970	R$ 651	-R$ 651
CUSTO TOTAL III	R$ 0	R$ 0	R$ 0
Incorridos	R$ 0	R$ 0	R$ 0
CUSTO TOTAL IV	R$ 0	R$ 0	R$ 0
Aprendizado	R$ 0	R$ 0	R$ 0
CUSTO TOTAL V	R$ 0	R$ 1.128	-R$ 1.128
Atualização por INCC	R$ 0	R$ 1.128	-R$ 1.128
CUSTO TOTAL	R$ 101.141	R$ 103.816	-R$ 2.675

INDIRETOS (Diluição)
-704 | G11 – Serviços Técnicos
-349 | G13 – Pessoal Permanente
+662 | G14 – Administração (Inclusão de gerador para recalque de drenagem no período obra)
-109 | G15 – Canteiro
-109 | G16 – SSO
-306 | G17 – Equipamentos

TORRE
-556 | Vertical (Vertical sem Varanda X Vertical com Varanda – Varanda possui QLP maior)
-288 | Concreto (Preço - Distribuição de fck)
ENEAS: 9,69 m³/U.H – 712,08 R$/m³
MARIANA: 9,79 m³/U.H – 733 R$/m³
+683 | Aço (Ajuste taxa de aço e atualização de preço)
ENEAS: 54,93Kg/m³ | R$6,53/Kg
MARIANA: 47,50Kg/m³ | R$6,43/Kg
-511 | Esquadrias de Alumínio (Mariana possui caixilho acústico + Caixilho varanda)
-103 | Instalações Hidráulicas (Instalações sem Varanda x Instalações com Varanda)
-901 | Elevador (Projeto)
ENEAS: 20PP – 2 Elev/torre – 1,5 m/s 14 passageiros | 18PP – 2 Elev/torre – 1,0 m/s 14 passageiros – 8 elevadores – **3.3032 R$/UH.**
MARIANA: 20PP – 2 Elev/torre – 1,5m/s 14 passageiros – 6 elevadores – **4.218 R$/UH.**

INFRA
-125 | Esquadrias de Ferro (Projeto)
-684 | Reservatório Metálico (Projeto)
ENEAS: 2 Reserv. Ø 3,82 – 10,20 | 17,10 m
MARIANA: 2 Reserv. Ø 3,18 – 24,80m
-243 | Paisagismo (Projeto)
+951 | Anexos (Projeto + Fundação dos Anexos)
+1.299 | Enterrados (Projeto – Recalque de Drenagem)

EEE
+508 | Projeto

ETE
+1.843 | Projeto

FUNDAÇÃO
-2.156 | Projeto
ENEAS: EHC Ø 35, 40, 50 – de 17 a 29 m – 18.205m – 195 R$/m
MARIANA: EHC Ø 60, 70, 80 – de 24 a 26 m – 7.401m – 470 R$/m

CONTENÇÃO
+1.487 | Projeto
ENEAS: Área de contenção: 506,03m² (de 1,2 a 5,0 m)
MARIANA: Área de contenção: 183,77 m² (de 1,2 a 5,0 m)

TERRAPLENAGEM
-1.312 | Projeto
ENEAS: Corte 2.882m³ | Aterro 15.996m³
MARIANA: Corte 3m³ | Aterro 7.930m³ | Aterro de Pré Carga 2.414 R$/UH

Operações

SISTEMA DE ABASTECIMENTO DE ÁGUA
Há viabilidade. Necessário uma extensão de aproximadamente 168m até a Rua Aloísio Magalhães.

SISTEMA DE ESGOTAMENTO SANITÁRIO
Há viabilidade. Foi considerado ETE e EEE por ser mais viável financeiramente.

SISTEMA DE DRENAGEM
Drenagem será por recalque, considerado ligação na sarjeta Rua Enéas Camargo.

SISTEMA DE ABASTECIMENTO DE GÁS
Abastecimento por GLP.

SISTEMA DE ABASTECIMENTO ELÉTRICO
Sem viabilidade. Considerada VB de 120K.

TERRENO

URBANIZAÇÃO
Considerado calçada na testada do empreendimento.

Operações

Matriz Risco Concessionária	
Água	Nível 3
Esgoto	Nível 3
Drenagem	NA
Elétrica	Nível 5
Gás	NA
Urbanização	NA

LEGENDA		
Nível	Tipo	Status
1	Com Diretriz	Conclusiva
2		Conclusiva com projeto aprovado
3		Conclusiva sem projeto aprovado
4		Não Conclusiva
5	Sem Diretriz	-
NA	-	Não aplicável

Água:
- Viabilidade emitida em 06/2025, com validade em 06/2027.

Esgoto:
- Viabilidade emitida em 06/2025, com validade em 06/2027.

Drenagem:
- Drenagem será por recalque com ligação na sarjeta da Rua Enéas Camargo.

Elétrica:
- Sem viabilidade, foi considerada VB de 120K. No pedido de ligação definitiva a concessionária pode vir a cobrar reformas necessárias, caso a infraestrutura existente não seja suficiente.

Gás:
- Empreendimento com GLP.

Urbanização:
- Considerada calçada na testada do empreendimento.

Fundação:
- Realizada 1ª campanha de sondagem a percussão contemplando 10 furos em agosto/2022.
- Realizada 2ª campanha de sondagem mista contemplando 10 furos em agosto/2022.
- Considerada Estaca Hélice, com diâmetros de 35, 40 e 50 e profundidade de 17 a 29m.

Logística

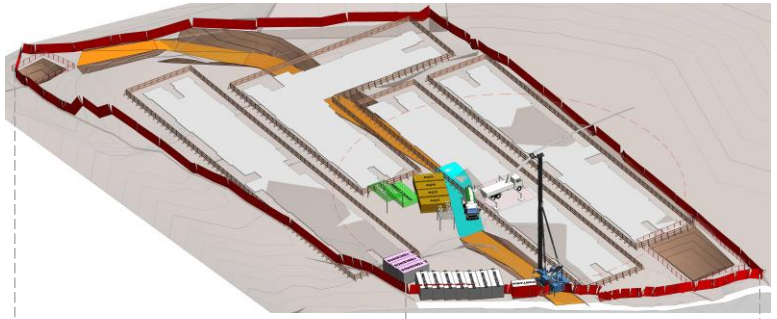

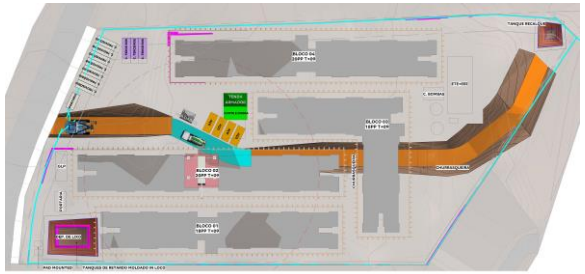

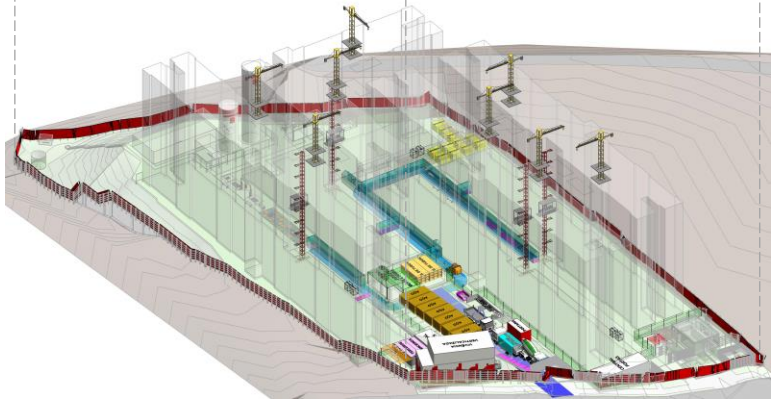

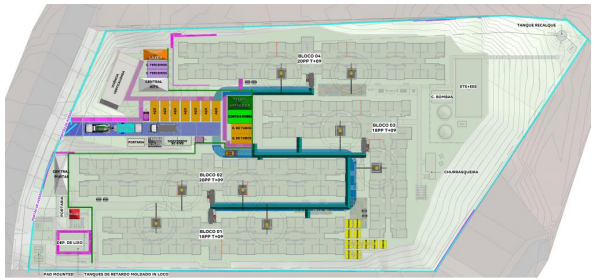

VIVÊNCIA - CONTAINERS							
DESCRIÇÃO	QUANTIDADE	TAMANHO MÓDULOS	MOBILIZAÇÃO	DESMOBILIZAÇÃO	PRÉ FORMA	ESTRUTURA	ACAB.
CONTAINER PORTARIA (LOG)	CONSIDERAR 1 MÓDULO COM SANITÁRIO E CATRACA	2,41 X 4,90 m	1 MOBILIZAÇÃO	1 DESMOBILIZAÇÃO	TODO PERÍODO	TODO PERÍODO	TODO PERÍODO
CONTAINER PROVISÓRIO (LOG)	CONSIDERAR 8 MÓDULOS DE CONTAINER	2,41 X 6,10 m	1 MOBILIZAÇÃO	1 DESMOBILIZAÇÃO	TODO PERÍODO	-	-
CONTAINER VIVÊNCIA VERTICALIZADA (LOG)	CONSIDERAR 17 MÓDULOS DE CONTAINERS E 1 ESCADA PARA ACESSO (SENDO 6 NO PAV T , 6 NO PAV 1 E 5 NO ULTIMO PAV.)	2,41 X 6,10 m	1 MOBILIZAÇÃO	1 DESMOBILIZAÇÃO	-	TODO PERÍODO	TODO PERÍODO

TENDAS_PERÍODOS						
DESCRIÇÃO	QUANTIDADE	LARGURA	COMPRIMENTO	PRÉ FORMA	ESTRUTURA	ACABAMENTO
GAIOLA DE DESMOLDANTE (LOG)	1	3,00	3,00	-	TODO PERÍODO	-
TENDA ARMADOR (LOG)	1	4,00	7,00	TODO PERÍODO	TODO PERÍODO	-
TENDA CENTRAL DE KITS (LOG)	1	4,00	8,50	-	TODO PERÍODO	TODO PERÍODO
TENDA CENTRAL DE PORTAS (LOG)	1	11,50	3,85	-	TODO PERÍODO	TODO PERÍODO
TENDA LAZER (LOG)	1	3,00	7,00	-	TODO PERÍODO	TODO PERÍODO
TENDA MOLDADOR (LOG)	2	3,00	4,00	TODO PERÍODO	TODO PERÍODO	-

LOG_EQUIPAMENTOS E MAQUINÁRIOS						
EQUIPAMENTO	QUANTIDADE	MOBILIZAÇÃO	DESMOBILIZAÇÃO	PRÉ FORMA	ESTRUTURA	ACABAMENTO
BETONEIRA (LOG)	VARIÁVEL	-	-	TODO PERÍODO	TODO PERÍODO	-
BOBCAT (LOG)	1 EQUIPAMENTO	1 MOBILIZAÇÃO	1 DESMOBILIZAÇÃO	-	TODO PERÍODO	CONSIDERAR 15 DIAS DO PERÍODO DE ACABAMENTO
BOMBA ESTACIONÁRIA PADRÃO (LOG)_R01	1 EQUIPAMENTO	-	-	-	TODO PERÍODO	-
BOMBA LANÇA RS (LOG)	VARIÁVEL	-	-	TODO PERÍODO	TODO PERÍODO	-
CAMINHÃO MUNCK (LOG)	1 EQUIPAMENTO	1 MOBILIZAÇÃO	1 DESMOBILIZAÇÃO	-	CONSIDERAR MEIO PERÍODO DE ESTRUTURA	-
CREMALHEIRA CDW (LOG)	4 EQUIPAMENTOS	1 MOBILIZAÇÃO	1 DESMOBILIZAÇÃO	-	TODO PERÍODO	TODO PERÍODO
MINIGRUA (LOG)	4 EQUIPAMENTOS	1 MOB POR MINIGRUA POR TORRE (TAKT 2X2)	1 DESMOB POR MINIGRUA POR TORRE (TAKT 2X2)	-	TODO PERÍODO	-
PERFURATRIZ (LOG)	1 EQUIPAMENTO	1 MOBILIZAÇÃO	1 DESMOBILIZAÇÃO	CONSIDERAR PERÍODO DE ESTACA CONFORME PROJETO.	-	-

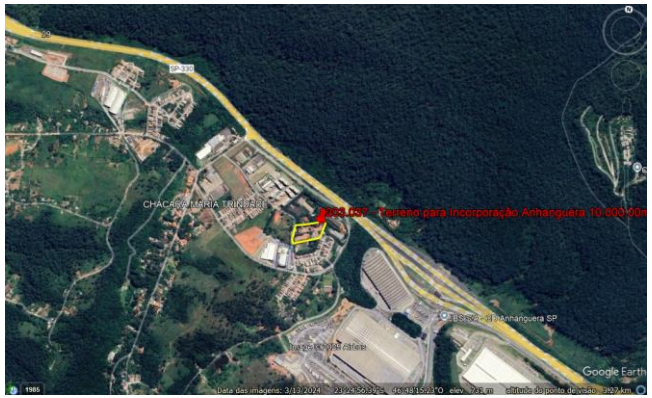

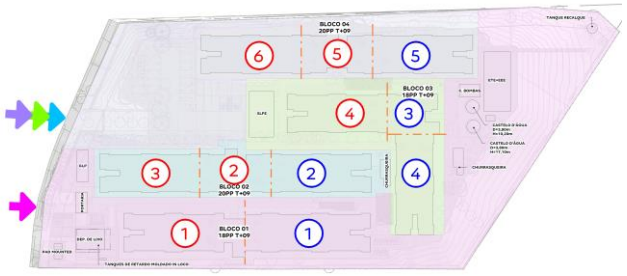

OBS.: 01

OBS.: 02

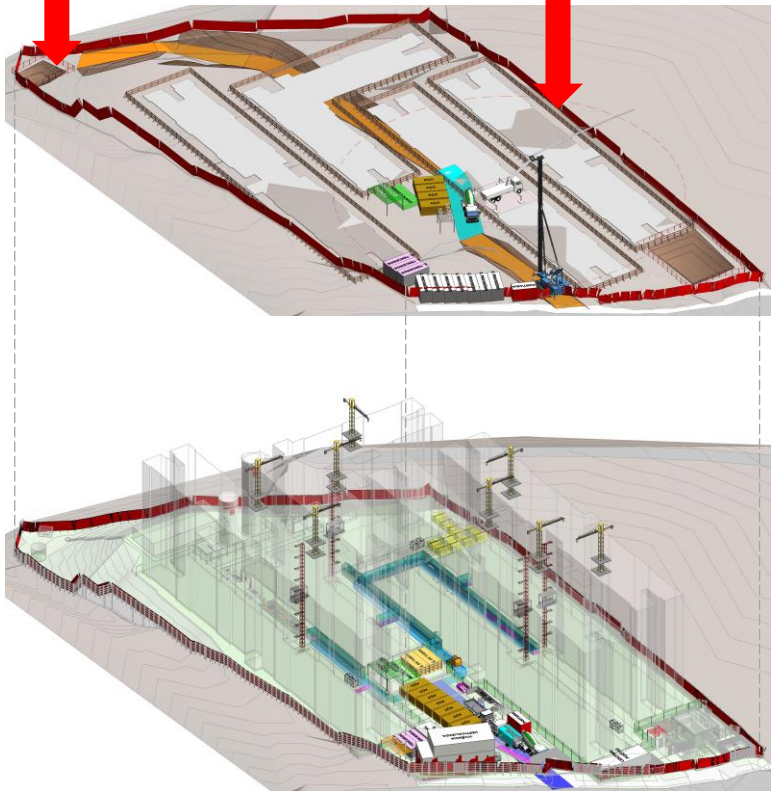

OBS.: 03

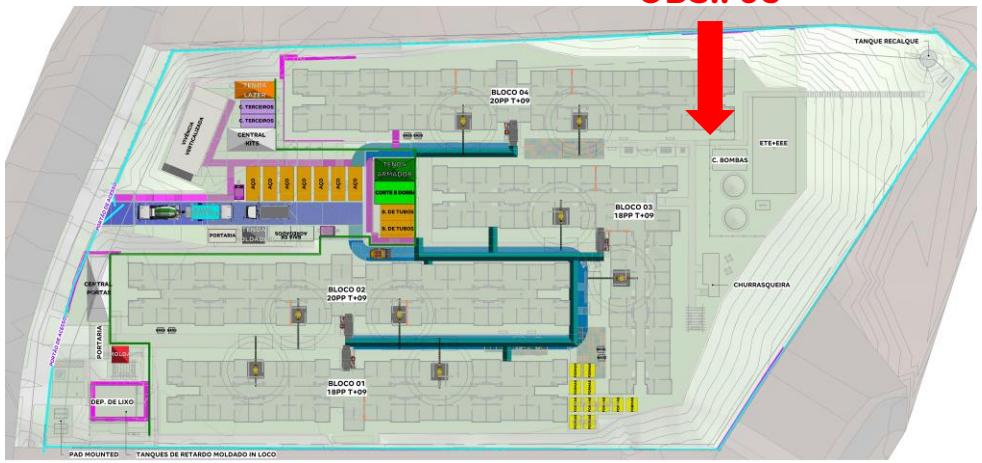

➢ OBS. 01	ENTERRADO AO FUNDO DO TERRENO DEVERÁ SER EXECUTADO NO INÍCIO DO PERÍODO DE PRE-FORMA, PODENDO OCORRER JUNTO A FUNDAÇÃO DA 1ª TORRE. APÓS INÍCIO DA FUNDAÇÃO DAS OUTRAS TORRES NÃO HAVERÁ ACESSO PARA EXECUÇÃO DESTE ENTERRADO.
➢ OBS. 02	CONTENÇÕES CRÍTICAS NAS DIVISAS DO TERRENO DEVERÃO SER EXECUTADAS NO INÍCIO DO PERÍODO DE PRÉ-FORMA, ANTES DA FUNDAÇÃO DAS TORRES. PREVER PRAZO.
➢ OBS. 03	FUNDAÇÃO DOS CASTELOS E SEU IÇAMENTO DEVERÁ OCORRER ANTES DO INÍCIO DAS FUNDAÇÕES DOS BLOCOS 03 E 04, POIS POSTERIORMENTE NÃO HAVERÁ ACESSO.

Logística

ITENS A SEREM CONSIDERADOS:

➢ **LEGALIZAÇÃO**	DEVIDO À QUANTIDADE DE ÁRVORES DE COMPENSAÇÃO PREVISTAS NESTA IMPLANTAÇÃO, DEVERÁ SER PREVISTO PRAZO ADICIONAL CONFORME AVALIAÇÃO DE LEGALIZAÇÃO E PÓS-LEG PARA NÍVEL DE CRITICIDADE 2 (ITENS DE LOGÍSTICA SOBREPONDO ÁRVORES E ÁREA PERMEÁVEL).***ATENÇÃO EM RELAÇÃO AS ÁRVORES EXISTENTES QUE DEVERÃO SER PRESERVADAS***
➢ **CUSTOS / OBRA**	PREVER CUSTO E PRAZO PARA EXECUÇÃO DE RAMPAS PROVISÓRIAS, CONFORME INDICADAS NA IMPLANTAÇÃO, PARA VIABILIZAR ACESSOS NO EMPREENIMENTO, GARANTINDO ASSIM A EXECUÇÃO DE FUNDAÇÃO/TERRAPLENAGEM. AS RAMPAS DEVERÃO SER ABSORVIDAS NO PROJETO DE TERRAPLENAGEM PROVISÓRIA, CONSIDERANDO O REFORÇO DE BASE PARA A PISTA PROVISÓRIA (CAMADA DE SACRIFÍCIO).
	PREVER CUSTOS COM LOCAÇÃO DE VIVÊNCIA VERTICALIZADA (T+2), DEVIDO À FALTA DE ESPAÇO NA IMPLANTAÇÃO PARA LOCAÇÃO DA VIVÊNCIA PADRÃO. CONSIDERAR 17 MÓDULOS DE CONTAINERS E 1 ESCADA PARA ACESSO (6 CONTAINERS NO PAVIMENTO TÉRREO, 6 NO 1° PAVIMENTO E 5 NO ULTIMO PAVIMENTO).
	PREVER CUSTO PARA EQUIPE DE MOVIMENTAÇÃO MANUAL DE MATERIAIS "FORMIGUINHAS" (2 FUNCIONÁRIOS ESTRUTURA, 2 FUNCIONÁRIOS ACABAMENTO E 2 FUNCIONÁRIOS PARA TRANSPORTE DE AÇO), DEVIDO À IMPOSSIBILIDADE DE ACESSO DE MAQUINÁRIOS AO LONGO DA IMPLANTAÇÃO PARA MOVIMENTAÇÃO/DESCARGA DE MATERIAIS.
	NÃO HÁ ALCANCE DO RAIO DO MUNCK PARA MOBILIZAR E DESMOBILIZAR A CREMALHEIRA DOS BLOCOS. ASSIM, A MOBILIZAÇÃO DEVERÁ SER FEITA COM A BOBCAT. PREVER LARGURA SUFICIENTE PARA PASSAGEM DESTE MAQUINÁRIO E PREVER COM SUPRIMENTOS CONTRATAÇÃO DE CREMALHEIRA COM CABINE DESMONTÁVEL. CASO A CABINE NÃO SEJA DESMONTÁVEL, SERÁ NECESSÁRIO CONTRATAR UM GUINDASTE DE GRANDE PORTE.
➢ **PRAZO DE OBRA**	PREVER PRAZO NO PERÍODO DE PRÉ FORMA PARA EXECUÇÃO DE CONTENÇÕES CRÍTICAS (CONFORME INDICADO EM PROJETO).

Pareceres

Análise da Mancha e Implantação

Prospecção

Operações

Inteligência de Mercado

Financeiro

Anexos

Demanda e Distribuição da Mancha

Potencial de Demanda			Lançados		Lançados + Landbank	
Mancha	CÓD.	Shr.	ANO	MÊS	ANO	MÊS
São Paulo Norte	SZN	27%	1.505	125	1.806	150

Empreendimento	Renda	Lançamento	mar/27	abr/27	mai/27	jun/27	jul/27	ago/27	set/27	out/27	nov/27	dez/27	jan/28	fev/28	mar/28	abr/28	mai/28	jun/28	jul/28	ago/28	set/28	out/28	nov/28	dez/28
Horizonte Jaraguá	2.562	dez-25	22	22	22	22	22	22	22	22	22	8												
Melodia Jaçanã - Fase 2	3.397	set-26	26	26	26	26	26	26	26	14														
Bela Vista Jaragua - F1	2.958	out-26	27	27	27	27	27	27	27	27	27	27	27	27	27	21								
Monte Trindade	**2.796**	**mar-27**		**42**	**42**	**42**	**42**	**42**	**42**	**42**	**42**	**42**	**42**	**42**	**42**	**42**	**42**	**42**	**42**	**42**	**37**			
Bela Vista Jaragua - F2	2.958	mar-28														26	26	26	26	26	26	26	26	26
Travessa Igarapé F1	**3.380**	**out-28**																					**51**	**51**
Travessa Igarapé F1	**3.380**	**abr-30**																						
Travessa Igarapé F1	**3.888**	**abr-30**																						
Travessa Igarapé F1	**3.380**	**out-31**																						
Total de Vendas Lançados			**0**	**0**	**0**	**0**	**0**	**0**	**0**	**0**	**0**	**0**	**0**	**0**	**0**	**0**	**0**	**0**	**0**	**0**	**0**	**0**	**0**	**0**
Total de Vendas Lançados + Landbank			**75**	**117**	**117**	**117**	**117**	**117**	**117**	**105**	**91**	**77**	**69**	**69**	**69**	**89**	**68**	**68**	**68**	**68**	**63**	**26**	**77**	**77**

Parecer de I.M sobre a mancha:

O projeto analisado em comitê está em linha com o potencial teórico de demanda calculado para a mancha. (Total Lanç + Landbank)

Canibalização:

Sem Risco de Canibalização

Monte Trindade | Mapa Concorrência

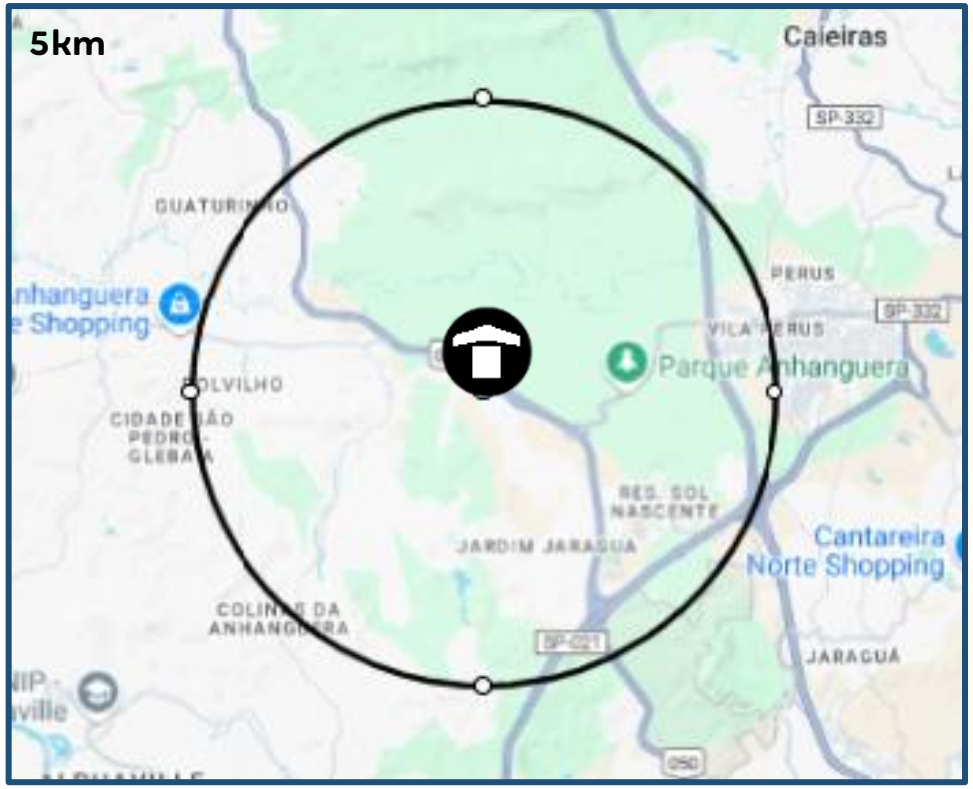

Diagnóstico Concorrência

- Não mapeamos novos lançamentos da concorrência na região.

Abaixo, seguem os dados sociodemográficos do projeto:

	Monte Trindade	
	TENDA	
Região 1 Km	População	856
	Dens. Demográfica	274
	Renda (R$)	3.515
	Classe Social	C1 (2.7k a 4.6k)
	PEA Dia	844

Simulação de Preço

Informações Viabilidade

Projeto:	Monte Trindade			
Tipo:	**HMP**		**HMP - Com vaga**	
Método	**Vision**		**Vision**	
Avaliação	220.000		240.000	
Renda Inicial (VF)	2.750		3.990	
Renda Final*	-		-	
% RET1	50%		0%	
Tipo:	**VF**	**R$**	**VF**	**R$**
Ato	0,87	2.388	0,59	2.336
FGTS	0,83	2.282	0,56	2.242
Financiamento	95,18%	155.707	97,68%	187.537
Subsídio	113,70%	16.041	162,57%	3.495
Prazo de Pró-soluto	30	30	30	30
Pró-Soluto	82,57%	24.750	66,84%	29.070
Preço Raso (RS)	201.168	201.168	224.681	224.681
TCD	59,75%	16.564	62,58%	25.169
VSO	40	40	2	2
Preço de Venda	**217.732**	**217.732**	**249.850**	**249.850**
Elasticidade	0,000%	0,000%	0,000%	0,000%
Preço de Venda Final	**217.732**	**217.732**	**249.850**	**249.850**
Preço Raso (R$)	**201.168**		**224.681**	
% de Raso	**92,39%**		**89,93%**	
BP25 - Não Inflacionado	-		-	
BP25 - Inflacionado	-		-	

Análise de Preço

Informações Viabilidade

Projeto:	Monte Trindade
Tipo:	**Faixa 2**
Método	**Vision**
Avaliação	220.746
Renda Inicial (VF)	2.796
Renda Final*	-

Tipo:	VF	R$
Ato	0,86	2.386
FGTS	0,82	2.281
Financiamento	95,27%	156.893
Subsídio	115,52%	15.573
Prazo de Pró-soluto	30	30
Pró-Soluto	81,98%	24.911
Preço Raso (RS)	202.044	202.044
TCD	59,86%	16.885
VSO	42	42
Preço de Venda	**218.929**	**218.929**
Elasticidade	0,000%	0,000%
Preço de Venda Final	**218.929**	**218.929**
Preço Raso (R$)	**202.044**	
% de Raso	**92,29%**	
Raso Todas as Fases	**202.044**	
Nominal Todas as Fases	**218.929**	

1

Análise de Riscos | Farol IM

IM avalia o Preço Vision como **factível**.

1) I.M está de acordo com o preço Vision, tendo em vista que, os projetos da regional já performam a renda estimada no parecer.

Conforme consta no slide "Panorama de Concorrência", não mapeamos novos lançamentos da concorrência na região.

Abaixo, segue o escalonamento da Regional:

	Preço Real					Preço Normalizado (30m)	
	Avaliação	Preço Raso	Renda Média	VSO	PSOL	Δ PSOL	Preço Raso
Parque Limão	240.120	217.010	3.800	60	20	11.773	228.783
Farol Cantareira	223.024	192.951	3.403	17	18	10.760	203.711
Melodia Jaçanã	253.372	241.392	4.400	83	33	-3.816	237.576
Viva City Jaraguá	223.201	193.336	3.584	27	13	16.626	209.962
Monte Trindade	220.746	202.044	2.796	42	30	-	202.044

Ciclo Financeiro – Análise Mancha

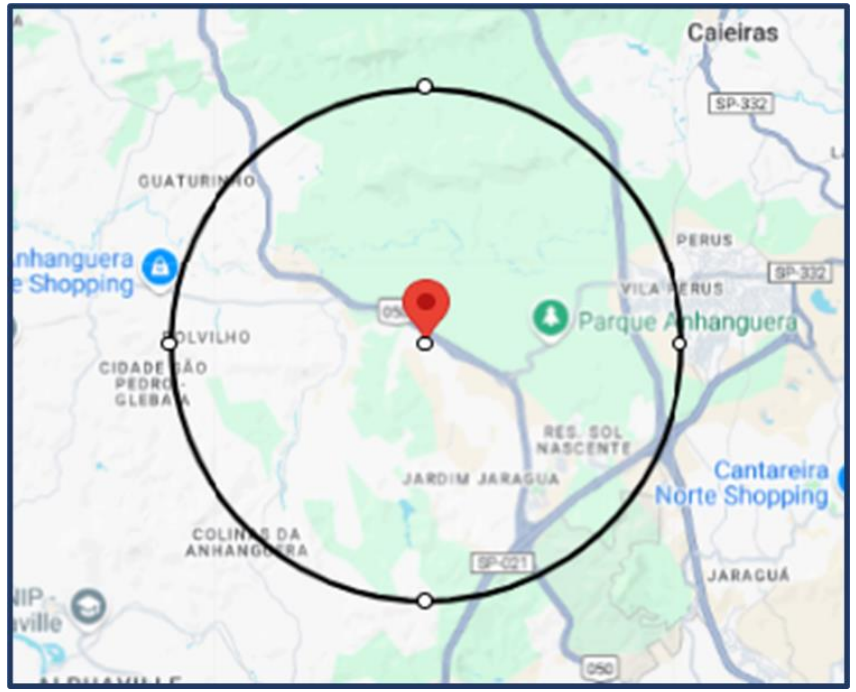

Parecer Ciclo

O Ciclo considerou o Preço e o VSO como viáveis. O projeto está localizado na rua em que lançamos o Solares Nascente e Ponte, sucesso de vendas, região em desenvolvimento, próximo à cidade de Polvilho e sem concorrência.

Pareceres

Análise da Mancha e Implantação

Prospecção

Operações

Inteligência de Mercado

Financeiro

Anexos

Informações Financeiras

Monte Trindade - SP - São Paulo Capital

Datas e Prazos

	Compra	Lançamento	Início Obra	Término Obra	LÇTO até IO	IO até TO	Chaves	LÇTO até Chaves
Consolidado	jul-25							
SEM VAGA		mar-27	set-27	out-29	6 meses	25 meses	mar-30	36 meses
COM VAGA		mar-27	set-27	out-29	6 meses	25 meses	mar-30	36 meses

Terreno e Incorridos

TOTAL (R$ + Perm.):	14,80 MM	**Incorrido Terreno:** 0,00 MM	**Área do Terreno (100%):**	10.000 m²	**Área Líquida do Terreno:** 9.820 m²
Cash:	0,00 MM		**Custo de terreno m²:**	1.479,7	**Custo de terreno m² Área Líquida:** 1.506,9
Permuta Financeira:	14,80 MM (9,00%)		**VaR 25 (R$ mil):**	0	**Fração Terreno/Terreno + Custo Obra (%VGV):** 9,0% / 55,2%
Permuta Física:	0,00 MM (0,00%)		**VaR 26 (R$ mil):**	0	**CA Máx/Proj.** 4,1 / 2,4
Ato / %VGV:	0,00 MM / 0,0%		**Incorrido de Construção:**	0,00 MM	**Incorridos de Incorporação:** 0,00 MM

Vendas

Fases	Nº Pavimentos	Preço Raso Unit.	Qtde	Preço Unit.	Aval. CEF	Cond. Parcela	% Pró-soluto	% TCD
SEM VAGA	T+9	201.168	723	217.732	220.000	95,2%	82,6%	59,8%
COM VAGA	T+9	224.681	28	249.850	240.000	97,7%	66,8%	62,6%

Unidades Totais:	751	**Preço Médio:**	218.929	**Renda Média:**	2.796	**ITBI+Emol. Unit. Médio:**	2.638
Unidades Tenda:	751	**Avaliação Média:**	220.746	**Ato:**	2.399 (0,86 Salários)	**Custo do Ciclo Unit.:**	13.781
VSO:	42 Unidades	**VGV Total:**	164.415.778	**FGTS:**	2.292 (0,82 Salários)	**Preço Raso Médio:**	202.044
RET Médio:	2,6%	**VGV Tenda:**	164.415.778	**% em RET 1%:**	48%	**Adc. Tx. de Aceleração Médio:**	750

Construção

Custo Total Unit. | Corrigido:	101.141 | 100.558	**Eventuais:**	4,00%	**Área priv (m²):**	32,00	**Gape / Mês Unit.:**	11,08

Resultado

LI (R$):	**19.397.975**	**LI:**	**20,48%**	**Exposição de Caixa (R$):**	**12.522.053**	**Margem Bruta Econômica:**	**36,24%**
TIR:	**175,16%**	**LI Aprovação:**	**20,00%**	**Ger. Caixa 12 meses (R$):**	**0**	**Margem Bruta REF:**	**39,15%**
Exposição de Caixa:	**6,97%**	**Δ LI:**	**0,48%**	**Ger. Caixa 24 meses (R$):**	**(3.124.269)**	**Margem Rasa Econômica:**	**30,17%**
Payback Contingente (21 m):	**19 m/ (-2 m)**	**LI Resiliência:**	**14,49%**	**Ger. Caixa Marginal (R$):**	**43.277.805**	**Margem Rasa REF:**	**34,07%**
Payback Consolidado:	**19 meses**					**Margem de Contribuição Econômica:**	**25,58%**

Informações Financeiras

R$ Mil - Valores Nominais - Compra	Monte Trindade		SEM VAGA		COM VAGA	
	Nominal	%	Nominal	%	Nominal	%
Receita	179.780	100,0%	172.081	100,0%	7.699	100,0%
PIS/COFINS	(2.528)	1,4%	(2.359)	1,4%	(169)	2,2%
Custo Total	(113.021)	63,8%	(108.716)	64,1%	(4.305)	57,2%
Custo Terreno	(14.724)	8,3%	(14.093)	8,3%	(631)	8,4%
Custo Relacionados a Terreno	(973)	0,5%	(933)	0,5%	(39)	0,5%
Custos de Incorporação	(3.396)	1,9%	(3.264)	1,9%	(133)	1,8%
Custo de Construção	(93.928)	53,0%	(90.426)	53,3%	(3.502)	46,5%
Lucro Bruto Econômico	64.231	36,2%	61.006	35,9%	3.226	42,8%
Custo para Rateio	-	0,0%	-	0,0%	-	0,0%
Lucro Bruto Contábil	64.231	36,2%	61.006	35,9%	3.226	42,8%
Despesas de Selling	(14.750)	8,3%	(13.994)	8,2%	(756)	10,0%
Contingência	(4.135)	2,3%	(3.958)	2,3%	(177)	2,4%
Margem de Contribuição	45.346	25,6%	43.054	25,4%	2.293	30,4%
IR e CSLL	(2.068)	1,2%	(1.930)	1,1%	(138)	1,8%
Margem Líquida	43.278	24,4%	41.123	24,2%	2.154	28,6%
Lucro Bruto REF Unit.	95.959	39,1%	94.803	38,9%	126.483	45,4%
Lucro Raso REF Unit.	77.076	34,1%	76.274	33,8%	98.447	39,3%

R$ Mil - VPL - Compra	Monte Trindade		SEM VAGA		COM VAGA	
	VP	%	VP	%	VP	%
Receitas	94.725	100,0%	90.721	100,0%	4.004	100,0%
PIS/COFINS	(1.312)	1,4%	(1.225)	1,4%	(87)	2,2%
Custos e Despesas Totais	(74.015)	78,1%	(71.031)	78,3%	(2.984)	74,5%
Custo Terreno	(7.426)	7,8%	(7.112)	7,8%	(314)	7,8%
Custo Relacionados a Terreno	(698)	0,7%	(670)	0,7%	(28)	0,7%
Custos de Incorporação	(2.026)	2,1%	(1.945)	2,1%	(82)	2,0%
Custo de Construção	(52.219)	55,1%	(50.272)	55,4%	(1.947)	48,6%
Despesas de Selling	(9.479)	10,0%	(8.984)	9,9%	(495)	12,4%
Contingência	(1.094)	1,2%	(1.047)	1,2%	(47)	1,2%
IR e CSLL	(1.073)	1,1%	(1.002)	1,1%	(71)	1,8%
Lucro Imobiliário	19.398	20,5%	18.464	20,4%	934	23,3%

Pareceres

Análise da Mancha e Implantação

Prospecção

Operações

Inteligência de Mercado

Financeiro

Anexos

- **DESCRIÇÃO DO IMÓVEL:** Matrícula: nº 251.732 do 18º Cartório de Registro de Imóveis de São Paulo/SP ("**Imóvel**"), situado na Rua Eneas Camargo - Lote A do Loteamento Sem Denominação. Contribuinte: nºs 203.084.0007-9 e 203.084.0006-0.

- **PROPRIETÁRIA:** EVOLVERE EMPREENDIMENTOS LTDA.

- **DA CONSULTA AO CADASTRO NACIONAL DE EMPRESAS INIDÔNEAS E SUSPENSAS (CEIS):** Não é objeto de análise pelo NFA.

- **CONSIDERAÇÕES SOBRE O IMÓVEL:** ESTUDOS TÉCNICOS E JURÍDICOS**:** Conforme os relatórios de Estudos Técnicos, emitido pela TOP Perícias em 07/10/2022 e Estudos Jurídicos emitido pelo NFA Advogados em 11/10/2022, foram apontadas, em suma, as seguintes considerações: **(a) Retificação de área:** Verificou-se que existem algumas diferenças significativas entre as situações física e registrária, no tocante à linha dos fundos e na lateral esquerda de seu perímetro devido à existência, em âmbito registral, de um segmento aos fundos do Imóvel que não consta em âmbito real, resultando em uma área de aproximadamente 205m² (duzentos e cinco metros quadrados) e ainda que o Imóvel é ocupado fisicamente pelo imóvel confrontante objeto da Matrícula nº 63.258 do 18º Oficial de Registros de Imóveis de São Paulo. Diante do exposto, por se tratar de **(i)** sobreposição constatada pelos próprios limites registrários; **(ii)** situação que possibilita a retificação das descrições perimetrais sem mudança significativa da sua área total, e **(iii)** área real correspondente a cadastros da Municipais, entendeu-se possível a tentativa de retificação de área registraria, fundamentada pelas alíneas "d" e "f", cumulativamente, ambas do inciso I, do artigo 213 da Lei nº 6.015/73 (Lei de Registros Públicos), considerando os dois trechos físicos do perímetro de 81,74m e 7,06m, como medida aos fundos do Imóvel, estando próximo a medida de registral de 90,0m e dentro do limite de 5% (cinco por cento); **(b) Loteamento:** imóvel situado dentro do perímetro do "Loteamento Sem Denominação", inscritos em Registro de Imóveis e, aparentemente, conforme informações de arruamento das Fichas Técnicas, regular perante a Prefeitura Municipal. Não foi localizado arquivamento de Memorial Descritivo e Contrato Padrão de venda dos respectivos lotes restante prejudicada análise pelas vias registrárias. Da análise dos poucos documentos arquivados, não foram identificadas restrições urbanísticas convencionais. **DD IMÓVEL**: **(a) Área construída**: Não há. No entanto, a Proprietária declarou a existência de requerimento nº 6022.22 para aprovação de projeto de construção, bem como apresentou alvará de demolição nº 2018-62.083-00 e certificado de conclusão de demolição nº 2019.63185-00, contemplando área de 1.927,00m²; **(b) Débitos Imobiliários**: Não há. **(c) Multas:** Não há; **(d) Ônus e Gravames**: Não há; **(e) Ocupação**: Em que pese a declaração da Proprietária de que a mesma exerce no Imóvel atividade de estacionamento de veículos e guarda/depósito de bens/objetos, obtivemos a informação de que tal atividade é exercida, de fato, pela Terram Engenharia de Infraestrutura Ltda., a qual possui, contudo, o mesmo quadro societário da Proprietária, razão pela qual não foi dispensada no âmbito das tratativas para assinatura do CVC a formalização da ocupação por meio de contrato de comodato. **(f) CONDEPHAAT, CONPRESP, IPHAN:** As certidões são negativas; **(g) DESAP:** Negativas. **(h) Função Social da Propriedade:** Imóvel não notificado em virtude do descumprimento da função social da propriedade.

- **PASSIVOS RELACIONADOS AO IMÓVEL:**

(I) **Vizinhança/Drenagem**: **Ação de Produção Antecipada de Provas nº 1005629-91.2021.8.26.0004**, em tramite perante a 4ª Vara Cível do Foro Regional da Lapa movida pela proprietária do imóvel vizinho, Hoperatriz Comércio e Representações Ltda. na qual alega que em razão de supressão arbórea realizada pela Proprietária no Imóvel, as águas das chuvas formam uma enxurrada em direção ao seu terreno causando extensos danos materiais e colocando em risco a vida das pessoas que lá trabalham. Após laudo pericial foi detectada a necessidade de realização de obras de drenagem no Imóvel. As partes se manifestaram com relação ao laudo pericial e atualmente aguarda-se nova manifestação do perito. **Conclusão**: referida ação não possui o condão de impactar propriamente a solvência da Proprietária Tabular, uma vez que não possui cunho pecuniário, tampouco condenação em verbas sucumbenciais. Contudo, há uma questão técnica de escoamento e drenagem de água pluvial que poderá ser transferida à Tenda quando da aquisição do Imóvel e deve ser analisada pela equipe técnica e legalização para fins da análise de eventuais impactos à consecução do Empreendimento e à sua viabilidade técnica e financeira. **Recomendações:** celebração de aditamento ao Contrato, com a definição de cláusulas contratuais que condicionem a aquisição à realização de obras de drenagem no Imóvel.

(I) **Passivo Ambiental**: Conforme Parecer Jurídico emitido pelo SPLaw em 07/12/2022 sobre os aspectos da responsabilidade ambiental da Companhia que possam decorrer da aquisição do Imóvel, considerando a existência do **Inquérito Policial nº 1500364-51.2021.8.26.0004** ("IP"), em tramite perante a 4ª Vara Criminal do Foro Regional da Lapa para investigar o cometimento dos delitos previstos nos artigos 50 e 54 da Lei 9.605/98 e do **Inquérito civil nº 14.0482.0000010/2021-6** ("IC"), em tramite perante a 5ª Promotoria de Justiça do Meio Ambiente da Capital, por destruir ou danificar floresta ou qualquer tipo de vegetação nativa ou de espécies nativas plantadas, objeto de especial preservação sem autorização ou licença do órgão competente no Imóvel, mesmos fatos apurados no IP. Ainda é mencionada a suposta contaminação de solo sem notória averiguação até o momento. **Conclusão:** conforme concluído, inclusive, pelo Parecer Jurídico emitido pelo SPLaw em 07/12/2022, a Tenda, na qualidade de adquirente e futura proprietária, poderá responder nas esferas civil e administrativa pela suposta supressão vegetal pretérita e contaminação ocasionada por terceiros, sendo pouco provável a tipificação/ocorrência da responsabilidade criminal; (ii) o passivo ambiental identificado até o momento é a contaminação do solo e a supressão vegetal de exemplares arbóreos sem autorização/licença. A Companhia, caso adquira o Imóvel sem que referido passivo seja regularizado, poderá inclusive ser oficiada a responder nos autos do IC pelos danos. **Recomendações:** celebração de aditamento ao Contrato, com a definição de cláusulas contratuais que condicionem a aquisição à remediação do Imóvel e regularização dos passivos ambientais.

- **PASSIVOS RELACIONADOS AO IMÓVEL:**

- **Pendência:** Análise integral de Procedimento nº 082975/2021-19 em tramite perante a CETESB, não foi apresentada pela Proprietária Tabular, uma vez que a CETESB vem se negando a disponibilizá-la, mesmo após determinação judicial exarada nos autos do Mandado de Segurança nº 1061180-69.2022.8.26.0053 e no respectivo Cumprimento de Sentença Provisório autuado sob nº 0012059-21.2024.8.26.0053.

- **CONSIDERAÇÕES SOBRE A PROPRIETÁRIA, SÓCIOS E ANTECESSORES:**

- **A) Proprietária:**
  Passivo: Não foram localizados apontamentos judiciais, entretanto, há contingência fiscal no âmbito federal e municipal, sendo necessário apresentação de extrato fiscal para apuração dos débitos.
  Patrimônio: R$ 102.932,07.

- **B) Antecessores:** Não foram localizados apontamentos cujo risco tenha sido reputado como possível de impactar a aquisição pretendida por V.Sas.

- **CONTINUAÇÃO: CONSIDERAÇÕES SOBRE A PROPRIETÁRIA, SÓCIOS E ANTECESSORES:**

CONCLUSÃO: Para os pesquisados acima restou mitigado o risco de caracterização de fraude contra credor e/ou fraude à execução. No mais, haja vista o formato comercial do negócio envolvendo o pagamento de percentual incidente sobre a venda de cada uma das unidades autônomas do empreendimento, entendemos que haverá saldo para fazer frente a eventual passivo até a venda da última unidade. Desta maneira, recomendamos que a Proprietária declare ciência na escritura de novação e confissão de dívida, e assuma responsabilidade pela quitação de eventuais débitos que recaiam sobre o Imóvel e/ou o Empreendimento, permitindo ainda que V. Sas. paguem diretamente tais dívidas, descontando os valores comprovadamente despendidos das parcelas do Preço.

LEGALIZAÇÃO E DPP

➢ **ÁREA DE IMPLANTAÇÃO**

- O terreno composto pela **Matrícula Nº 251.732 – 10º CRI**, em nome de pessoa jurídica, que totaliza área **escriturária de 10.000,00m²** e área **real de 9.794,59m²**;
- O cadastro do imóvel é urbano;
- O cenário foi desenvolvido sobre a **poligonal** definida através do estudo jurídico **que corresponde a área de 9.978,32m²**;
- BDT emitido não indica interferência;

➢ **DIRETRIZES URBANÍSTICAS**

- O terreno esta inserido em **ZPI-2**, conforme **Decreto 63.728/2024**:

  C.A. máximo: **2,25** para **EHIS**, **gabarito: 28m** e **T.O.: 0,70%** e **P.A.: 3**, necessário reserva de calçada.
- Terreno não será parcelado, sem exigência de doação de áreas publicas;
- O estudo considera implantação de 1 condomínios (Com 751 UH), sendo:

  MÓDULO 1: 1 torre x T+09 e, com 178 UH(Sendo 06 PCD);

  MÓDULO 2: 1 torre x T+09 e, com 198 UH (Sendo 06 PCD);

  MÓDULO 3: 1 torre x T+09 e, com 177 UH (Sendo 06 PCD);

  MÓDULO 4: 1 torre x T+09 e, com 198 UH (Sendo 05 PCD) | 30 vagas de carro (sendo 1 PCD e 1 idoso) 10 vagas de moto;

  Possíveis Benefícios: HIS-1/50% (em toda cidade) = **1,12** | 10+20% Cota solidariedade = **0,67** | **Total CA com benefícios = 4,05**

  C.A. projetado: **2,38** (benefício utilizado: HIS-1 50% **0,13**)
- Em função do zoneamento não exigido cota a parte;
- A legislação não exige vaga de garagem, o cenário prevê vagas, sendo: 30 vagas de carro, 10 vagas para moto e 23 PCD)
- Usos permitidos: EHIS e EHMP.

LEGALIZAÇÃO E DPP

➢ **GRAPROHAB**

- Diretrizes SABESP: Emitida em 16/06.
- Não será a necessidade submeter aprovação em Graprohab;

➢ **AVALIAÇÕES AMBIENTAIS**

Arbóreo

- Conforme consulta no SP + Fácil , o terreno **não** é considerado como Patrimônio Ambiental;
- Não incide sobre o terreno APP;
- Não Incide sobre o Terreno Fragmento Florestal;
- De acordo com o cadastramento arbóreo, ao todo, foram cadastrados 156 indivíduos arbóreos isolados, ambos no interior da propriedade. Do total, 122 são de origem nativa, 30 de origem exótica e 04 exemplares mortos. Foi identificado 01 exemplar da espécie Araucária angustifólia (pinheiro do paraná).
- A propriedade não está inserida em Área de Patrimônio Ambiental (APA), Área de Proteção de Mananciais (APRM) e Unidade de Conservação;
- Cenário considera a supressão de todos os exemplares localizados no interior do lote;

Compensação

Nativas: 10:1 = 1.220

Exóticas: 1:1= 30

Protegidas: 1:30 = 30

Mortas e/ou tocos: 1:1= 4

- A compensação final para a supressão de todos os exemplares arbóreos, a considerar a categoria de uso, HIS, é de 1.304 mudas DAP 3,0 cm.
- O AP cenário 3, apresenta 156 mudas, sendo necessário deliberar 1148.

Hidrografia

- O Imóvel não apresenta corpos d’água internos ao perímetro ou próximo;

LEGALIZAÇÃO E DPP

➢ **COMAER**

Não há necessidade de aprovação.

➢ **AVALIAÇÕES AMBIENTAIS**

Contaminação (Contaminado)

C – Investigação Confirmatória

- O terreno não é objeto de contaminação, porém área é classificada como *''Área com Potencial de Contaminação (AP)''*, devido a atividade anterior.

- Seguiremos com o processo para uso residencial perante CETESB. A estratégia será contactar a empresa que apoiou o terrenista, daremos continuidade ao processo administrativo em aberto.

➢ **ÓRGÃOS DE PATRIMÔNIO HISTÓRICO**

- Municipal – Conpresp: Isento de deliberação;
- Estadual – Condephaat: Isento de deliberação;
- Federal – IPHAN: Será solicitado;

LEGALIZAÇÃO E DPP

➢ **ABASTECIMENTO SANITÁRIO**

- Certidão de Diretrizes OD 1280/2025_ON

Água: Para conexão do empreendimento ao sistema de abastecimento de água da Sabesp, deverá ser executado **reforço de rede** de água em ferro fundido, com PN 25, e diâmetro nominal mínimo de 250mm, desde a frente do imóvel até a rede existente da Sabesp cadastrada à Rua Aloísio Magalhães esquina com Rua Enéas Camargo, com diâmetro 400mm.

Esgoto:

O empreendimento será interligado ao **sistema público existente**, situado ao acesso da Rua Charqueada nas proximidades da Rua Leonel Martiniano, ou diretamente em um dos PVs do coletor tronco Itaim assim que este entrar em operação, conforme indicado em croqui anexo, através de rede coletora em PVC 300mm. A ligação será do tipo dimensionada especial de PV para PV.

- **DRENAGEM**
- O projeto prevê drenagem parcial, sendo parte executada por gravidade para a frente do lote(região da implantação das torres – cota 754,15) enquanto a porção em conta inferior à implantação dependerá de recalque.

LEGALIZAÇÃO E DPP

- **URBANIZAÇÃO**

- Conforme Certidão DESAP: N°1816/2022/PROJ-004, **não consta** DUP/DIS ou ação visando a desapropriação do imóvel, bem como o mesmo não é atingido por plano de melhoramento viário ou sanitários;

- **CONTRAPARTIDA**

- Não há.

- **OUTROS ITENS NECESSÁRIOS/ESPECÍFICOS**

- Terreno possui um Auto de Infração devido a supressão sem autorização por parte do órgão competente;
- Atividade atual é considerada como: *Área com Potencial de Contaminação (AP)*, sendo necessário o encerramento do uso industrial instalado;

CRONOGRAMA

MÊS	RESP	ETAPA	INÍCIO	FIM	STATUS/ PRAZO (dias)	0	1	2	3	4	5	6	7	8	9	10	11	12	13	14	15	16	17	18
	LEG	DESAP	11/6/25	26/7/25	40																			
	LEG	MELHORAMENTO VIÁRIO	11/6/25	16/7/25	30																			
	LEG	FICHA TÉCNICA	11/6/25	6/7/25	20																			
	LEG	COMAER	11/6/25	26/6/25	15																			
	LEG	CERTIDÃO AMBIENTAL (AIA)	11/6/25	1/7/25	15																			
	LEG	DIRETRIZES HIDRÁULICAS	11/6/25	24/9/25	100																			
	LEG	INVESTIGAÇÃO COMPLEMENTAR	3/7/25	25/7/25	22																			
	LEG	AVALIAÇÃO DETALHADA/RSH/INTERVENÇÃO	1/8/25	30/9/25	60																			
	LEG	DIRETRIZ DA SABESP	17/4/25	16/6/25	60																			
	LEG	REVISÃO CADASTRAMENTO ARBÓREO	1/7/25	16/7/25	15																			
	LEG	IPHAN	1/7/25	31/7/25	30																			
0	PROSP	COMITÊ INVESTIMENTO	26/6/25	26/6/25	-																			
	NEG	REUNIÃO PASSAGEM	3/7/25	3/7/25	-																			
	DPP	REVISÃO AP	3/7/25	23/7/25	20																			
	GETEC	ENGENHARIA SIMULTÂNEA	18/7/25	1/9/25	45																			
	GETEC	REVISÃO DIRETRIZ SABESP	7/8/25	21/9/25	45																			
	GETEC	ELABORAÇÃO PROJETO SABESP	14/8/25	12/12/25	120																			
	GETEC	APROVAÇÃO SABESP	19/12/25	18/4/26	120																			
	GETEC	EP KIT LEGAL	2/9/25	6/1/26	126																			
	PL	ELABORAÇÃO PL	2/8/25	16/9/25	45																			
	LEG	CETESB (CONTAMINADO)	15/10/25	13/4/26	180																			
	LEG	ALVARÁ DE APROVAÇÃO E EXECUÇÃO	22/10/25	22/10/26	365																			
	LEG	DISPENSA DE GRAPROHAB	23/8/26	12/9/26	20																			
	JRI	ESCRITURA	31/10/26	30/11/26	30																			
	JRI	REGISTRO INCORPORAÇÃO	20/11/26	20/12/26	30																			
	CRD	LAUDOS CEF	1/10/26	30/12/26	90																			
18	NEG	LANÇAMENTO	30/12/26	30/12/26	-																			

*Considerado em VF 3 meses adicionais para conclusão dos estudos ambientais. Prazo que poderá ser antecipado.

Obrigado