Tenda

sua próxima conquista

Book de Investimento - **Comitê Essencial**

Regional: SP – Zona Norte

Projeto: Spazio Primavera

Data Comitê: 26.06.25

Nome	Spazio Primavera - Essencial	Observação - Spazio Primavera
Fabricio Quesiti Arrivabene	Aprovado	ok
Alexandre Regis de Oliveira	Discutir em Comitê	As fotografias via satelite mostram uma grande quantidade de entulho sendo jogado ao longo dos anos , podendo resultar em inviabilidade técnica no que tange as fundações e instalações do projeto. Sugiro revisitarmos as condições financeiras ao término da Etapa 1 das condições resolutivas
Amanda da Silva Bezerra	Aprovado	ok
Alejandro Octavio Abiusi	Aprovado	ok
Rodrigo Osmo	Aprovado	N/A
Renan Barbosa Sanches	Aprovado	belo negocio. impressao de que da pra adensar mais e qualificar mais o produto. interessante avaliar como conseguimos fazer para reter para nos o ganho ao inves de distribuir a permuta extra no futuro
Luiz Mauricio de Garcia Paula	Aprovado	ok
Andre Luis Menegazzo Padilha	Aprovado	Ok

1. Perguntas Alexandre Regis de Oliveira

(i) As fotografias via satélite mostram uma grande quantidade de entulho sendo jogado ao longo dos anos, podendo resultar em inviabilidade técnica no que tange as fundações e instalações do projeto. Sugiro revisitarmos as condições financeiras ao término da Etapa 1 das condições resolutivas

R: O terreno ao longo dos anos sofreu alterações, como visualmente identificado. O proprietário alega que fez um aterro regular. Contratualmente, além de outras responsabilidades do vendedor, temos expressamente previsto que a responsabilidade sobre aterros irregulares será também do vendedor. Adicionalmente, caso esse aterro venha a contaminar o solo e/ou se identifique outra fonte de contaminação, podemos descontar do preço até 10% do valor do terreno (3,8MM). Ao longo da primeira etapa de resolutivas estaremos nos aprofundando nos estudos técnicos do terreno, em especial na sondagem, para concluir se o aterro poderá interferir na viabilidade do empreendimento.

3.8 O **VENDEDOR** se responsabiliza integralmente por todos e quaisquer prejuízos ou danos ao meio ambiente e à legislação urbanística relacionados ao Imóvel e/ou Lotes ou provenientes de seu uso até a data da imissão da **COMPRADORA** na sua posse, incluindo-se, mas não se limitando, a multa, danos envolvendo contaminação de solo e água subterrânea, remoção de vegetação da área sem que sejam observados os requisitos legais aplicáveis, danos nas áreas de preservação (se o caso), dano em "área *non edificandi*" (se for o caso), aterros irregulares (se for o caso) ou, ainda, qualquer outra violação à legislação ambiental, bem como por providenciar o desembargo da área

1. Perguntas Renan Barbosa Sanches

(i) Belo negócio, impressão de que da para adensar mais e qualificar mais o produto. Interessante avaliar como conseguimos fazer para reter para nos o ganho ao invés de distribuir a permuta extra no futuro

(DPP) R: Após contratação dos materiais técnicos, confirmação da poligonal e da FNA do terreno, buscaremos maximizar o adensamento do projeto, bem como a qualificação do produto, com a especificação dos atributos. Entretanto, o terreno possui um trecho destacado em amarelo no desenho abaixo, com taludes e uma topografia desafiadora, o que dificulta e inviabiliza a ocupação, reduzindo a área implantável para 16.842,95.

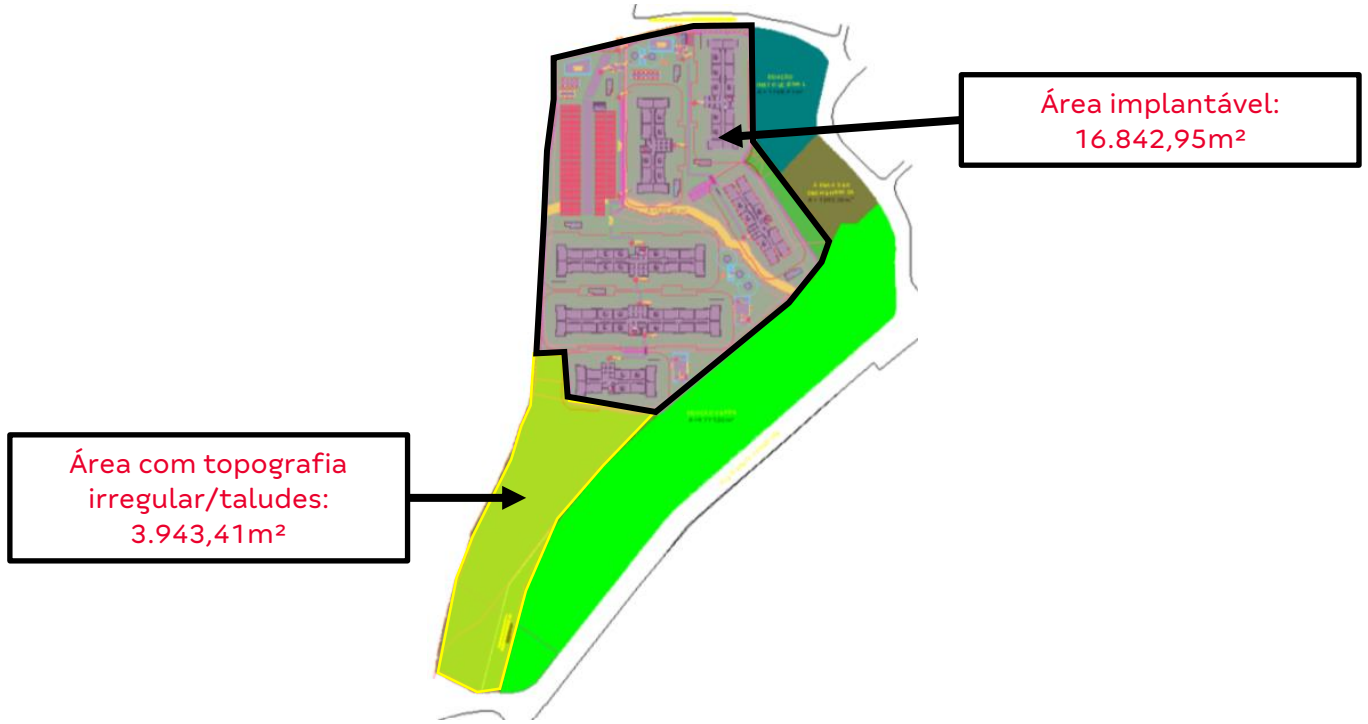

One Page – Spazio Primavera

Cidade	São Paulo	**Mancha de demanda**	SP - SZN1 - São Paulo Norte 1
Regional	SP	**Cluster MPR**	1 - Vermelho
Cenário de Aprovação	Aprovação	**Tipo de Aprovação**	Consolidado
Fase Anterior	N/A		
Tipo de Comitê	Essencial	**Versão da VF**	Versão 1.0: Jun

Unidades (% Vagas)	2154 (3%)	**CA Máx | Proj**	7,2 | 3,4
Tipologia	F2E - Concreto	**Escritura**	ago-28
Fases	3 fases	**Lçto | Duração (m)**	out/28 | 70

Valor Líquido do Terreno (% VGV)	35.344 (7,4%)	**Un. Perm. Fís (% Ter)**	0 (0,0%)
Cash (Correção)	0 (N/A)	**%VGV Perm Fin Líquida (% Ter)**	7,4% (100,0%)
Valor R$/m²	1.947	**VAR (%VGV)**	000 (0,0%)

Custo Construção (%VGV)	213.351 (44,8%)	**Indireto Unit.**	15.564
Prazo da Obra (meses)	24	**Torre Unit.**	55.956
Custo Total Unit. | Corrigido (LPU):	99.049 | 99.559 (LPU 89)	**Infra Unit.**	15.337
Início de Obra	abr-29	**Fundação Unit.**	8.332

Preço Nominal Unit.	220.996	**VSO**	40
Preço Raso Unit.	204.180	**Referência**	Estimativa
Avaliação Unit.	225.659	**Renda (% em RET 1%)**	3.397 (24,2%)

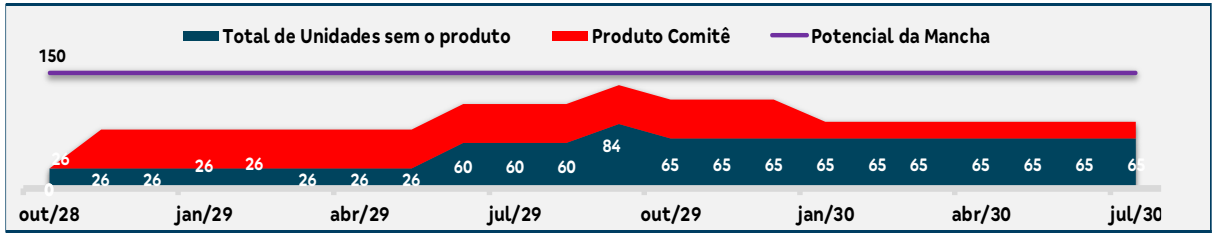

LI (Régua):	**21,3% (20,0%)**	**Margem Bruta Econômica:**	38,0%
LI Resiliência:	7,8% (N/A)	**Margem Rasa Econômica:**	32,2%
Margem Bruta REF:	40,9%	**Margem Contribuição Econômica:**	27,4%
Margem Rasa REF:	**36,1%**	**Exposição (% VGV):**	20.390 (3,4%)
TIR:	143,9%	**VGV Total:**	476.026
Payback Contingente (21 m) :	**19 m/ (-2 m)**	**Ger. Caixa 12 meses (R$):**	-
Payback Consolidado:	19	**Ger. Caixa 24 meses (R$):**	-

Destaques

[1] O Terreno está localizado na Travessa Igarapé Primavera, 92 no Bairro Tremembé, mancha ZN2 - Zona Norte de São Paulo. Região de borda, porém localização em potencial visto a proximidade com o empreendimento Melodia Jaçanã (~2km de distância) . Terreno ZEIS 5, sem limite de gabarito e com área bruta de 35.3mil m²/área líquida de 20,8mil m², viabilizado com T+25, 2 condomínios e 6 torres, com 3% de vaga de carro;

[2] O projeto é composto por 2 condomínios e um total de 2.154uh, sendo que: (i) Condomínio 1 com 921 uh em fase única; (iI) Condomínio 2 com 1.233 uh em duas fases. CA do projeto está em 3,11x sendo o máx 7,2X – Topografia, formato do terreno, e condições de acesso dificultaram aumento do CA implantado; na fase de desenvolvimento avaliaremos tema de atributos nas unidades e área comum.

[3] Condição Comercial: 100% em permuta financeira

- 8,5% de permuta bruta com desconto de 12,65%, resultando em uma permuta líquida de 7,4%; estimativa na viabilidade de 40,5MM na permuta Bruta e 35,3MM na permuta líquida;
- O contrato indica uma estimativa de 46,5MM porém sem compromisso ou obrigação além da permuta bruta de 8,5%, e um preço mínimo garantido de 38,0MM sem condição de correção e sem prazo para quitação; como não há correção no PMG, a viabilidade atingirá uma permuta superior ao PMG considerando a inflação;
- **OBS:** Aproximadamente R$ 538/CA e R$ 1.6773/m2 (ref. base valor terreno no PMG 38MM e cálculo sobre área remanescente)

[4] Condições Resolutivas:

a) Etapa I: Prazo 120 dias para resolutivas técnicas, resolutivas jurídicas e financeira; Etapa II: 90 dias para regularização cadastral do imóvel. Etapa III 24 meses após a superação da Etapa I para aprovação de projeto, contratação CEF, análise técnica, financeira e comercial para o lançamento do empreendimento;

b) A critério da Tenda podemos suspender o contrato pelo prazo que for necessário, suspendo as obrigações de pagamento e lavratura da escritura;

[5] Projeto para aprovação no formato de Comitê Essencial, dentro da régua de 20% de LI e baixa de 70% das unidades; temos expectativa de trazermos para comitê Ampliado no 2S25.

Pareceres

Análise da Mancha e Implantação

Prospecção

Operações

Incorporação

Inteligência de Mercado

Financeiro

Anexos

Pareceres

Área	Riscos Associados	Parecer	Criticidade
Jurídico	vDe acordo com a DD prévia entendemos ser viável darmos andamento aos próximos atos a serem praticados para a efetiva aquisição do terreno e que na DD detalhada em conjunto com estudo jurídico e técnico teremos maiores informações sobre o proprietário, imóvel e área ocupada por construções consolidadas. Em virtude dos apontamentos nas certidões, não se descarta a possibilidade de homonomía, e que não são segredo de justiça estamos realizando o levantamento e os em segredo de justiça, solicitamos esclarecimentos ao proprietário. Será necessário até a lavratura da escritura a desocupação do imóvel e a regularização perante municipio e INCRA, bem como a regularização da área construída.	Ok com ressalvas	
Legalização	Necessária atenção aos estudos técnicos para avançar nas etapas licenciamento, para próxima etapa deverá ser superado, estudo de descacterização de APP e conclusão do entendimento da regularização de áreas construídas em APP (demolição)	Ok	
DPP	N/A	Ok	
Inteligência de mercado	IM avalia o Preço Vision como factível	Ok	
Prospecção	Projeto com 2.151 uh divididos em dois condomínios, localizado próximo ao Melodia Jaçanã. O contrato encontra-se assinado e vigente, com a condição de 100% permuta financeira. Seguiremos com a baixa de 70% no Comitê Essencial, com previsão para o Comitê Ampliado em 120 dias.	Ok	
Estudos Econômicos	N/A	Ok	
Comercial/Ciclo	O Ciclo avaliou o preço e o VSO como factíveis. O projeto está localizado em uma região estratégica e com grande potencial, próxima ao lançamento Melodia Jaçanã. No entanto, encontra-se em uma microrregião inferior. Em junho, a Plano divulgou no Meeting o Plano&Jaçanã, concorrente direto do Melodia Jaçanã, voltado para famílias de renda média acima do Spazio Primavera. As unidades variam entre apartamentos com varanda sem vaga (renda média R$ 5.500, a partir de R$ 249.900) e varanda com vaga (renda média R$ 6.900, a partir de R$ 309.900). Apesar dessa concorrência, o Spazio Primavera se posiciona para um público diferente, com foco na demanda específica de sua região de inserção.	Ok	

Pareceres

Análise da Mancha e Implantação

Prospecção

Operações

Incorporação

Inteligência de Mercado

Financeiro

Anexos

Localização

Arena Zona Norte - Beach Tennis

Arena Saruê Beach Zona Norte - Beach Tennis

Metrô Tucuruvi

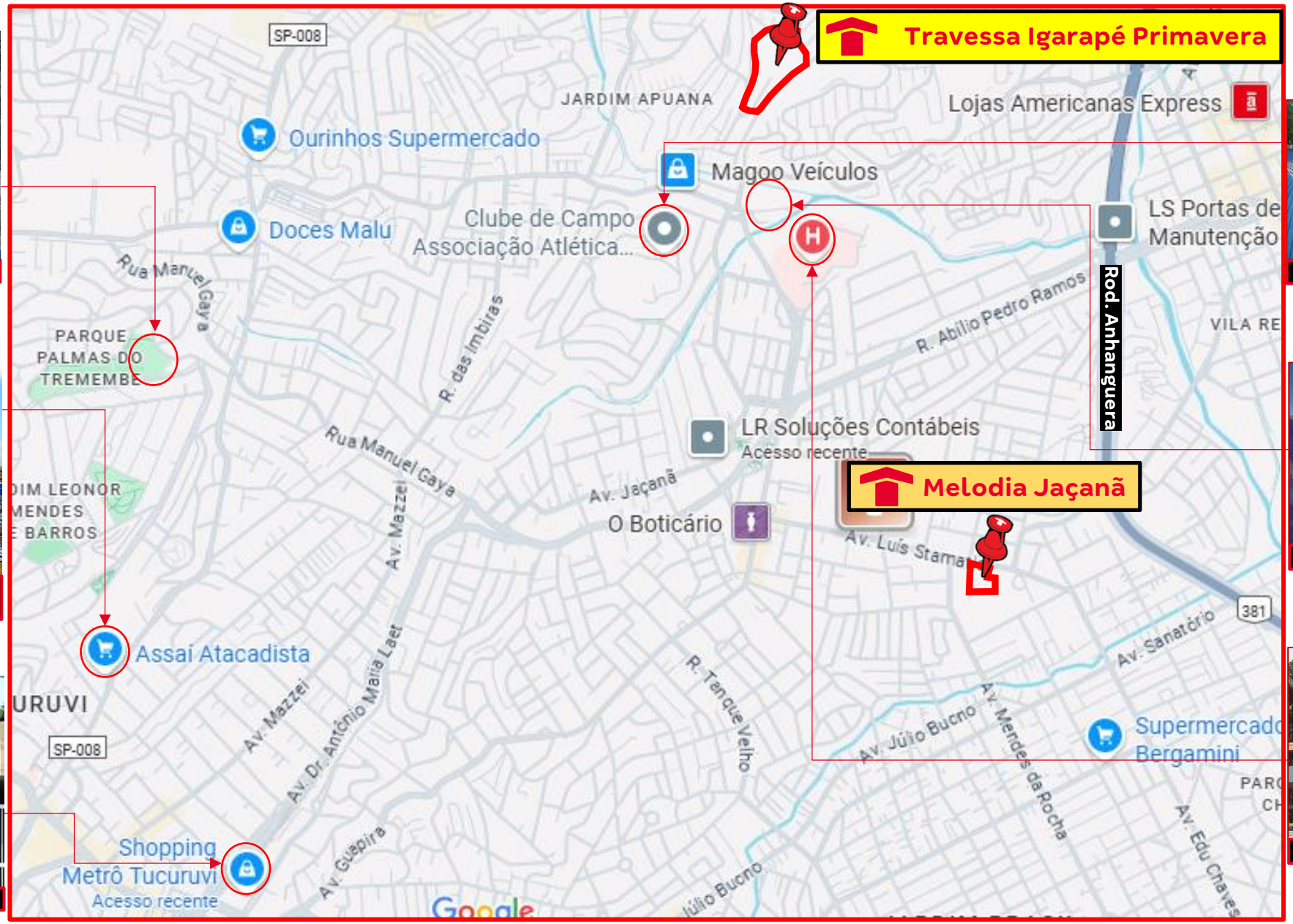

Clube de Campo Associação

CEU Jaçanã

Hospital São Luiz Gonzaga

Localização

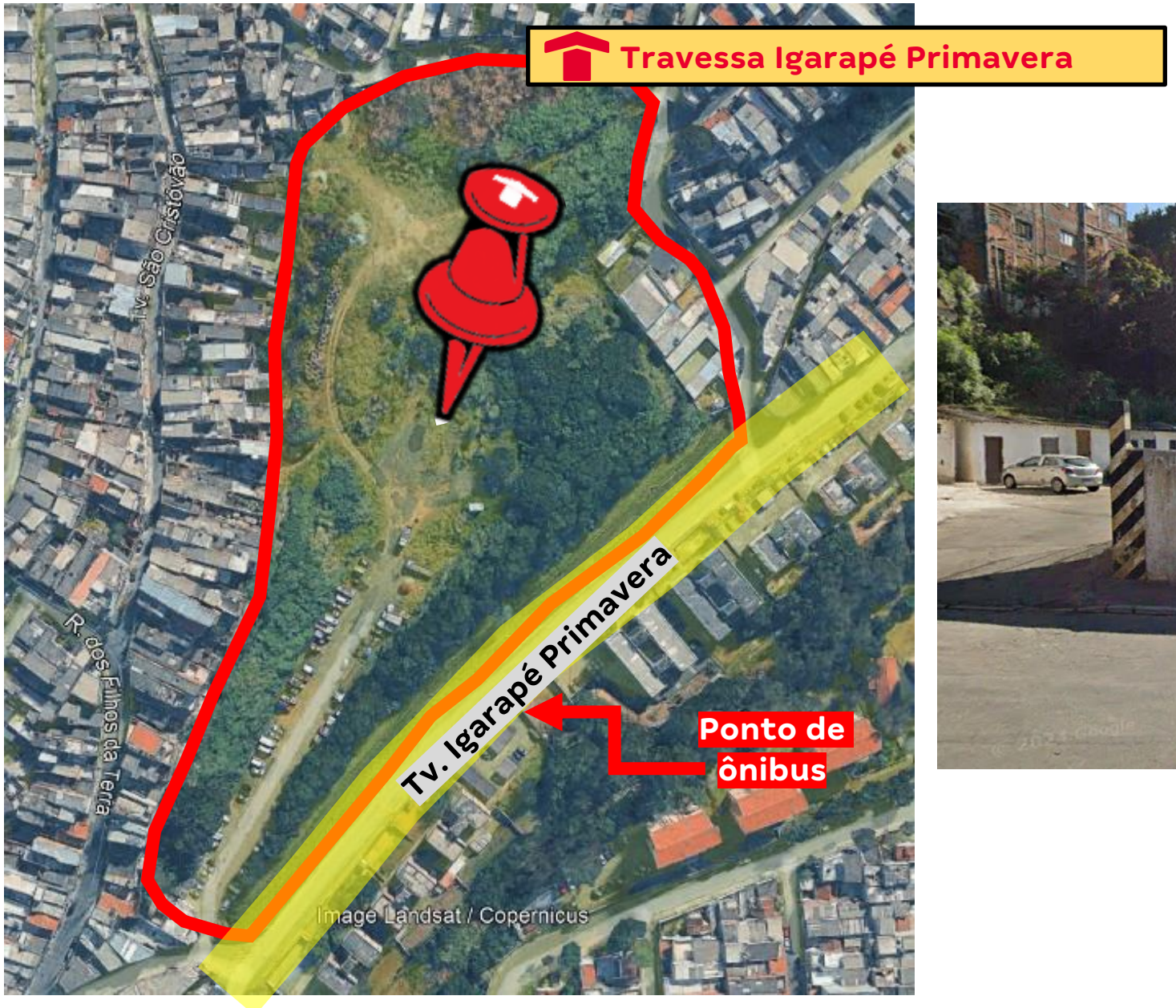

Mancha de Demanda

MANCHAS DE DEMANDA

• SZN – São Paulo Norte

Lançamento

1. Viva City Jaraguá
2. Viva Limão | Parque Limão
3. Portal do Parque
4. Farol Cantareira
5. Melodia Jaçanã

LandBank

6. Horizonte Jaraguá
7. Chácara Pirituba
8. Nilo Cairo
9. Bela Vista Jaraguá
10. Reserva Jaraguá
11. Monte Trindade
12. Spazzio Primavera

Cluster MPR – (Comitê)

Cluster 1 - Vermelho

Região

Borda

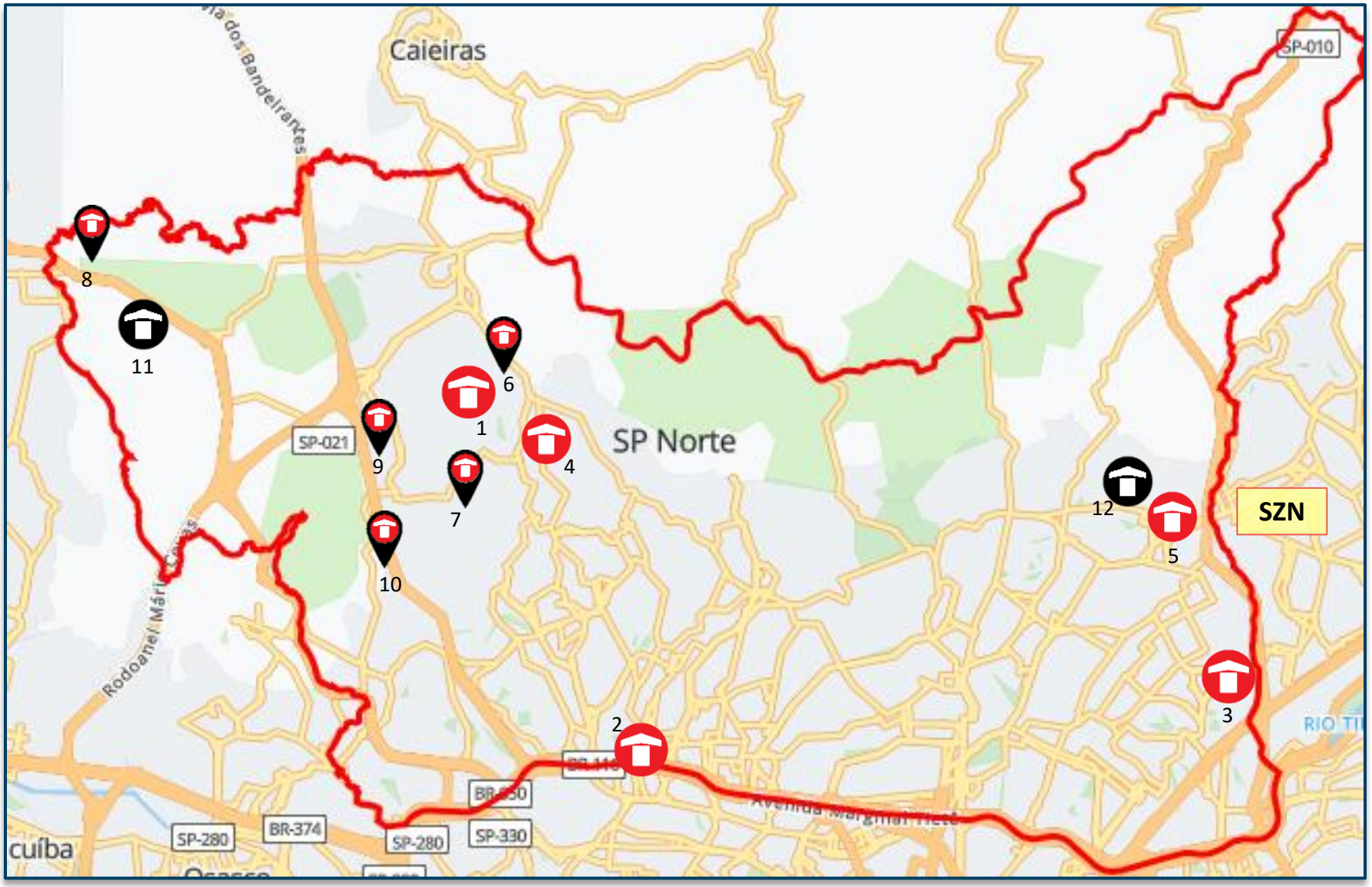

Lançados *LandBank* *Comitê*

PRODUTO

Travessa Igarapé Primavera
Investimento

Informações Gerais – Todos os Condomínios			
Terreno	Área terreno	35.348,53m²	
	Áreas de doações	12.633,36m²	
	Área remanescente	22.715,17m²	
	Menor poligonal	35.348,53m²	
	APP/FNA	Sim - 537,04m	
	Reserva de calçada/ melhoramento viário	227,73m²	
	Área liquida	20.784,69m²	
	Zoneamento	ZEIS-5 | ZEIS-2	
	Ca máximo	7,20	ZONA: 4,0
			INCENTIVO HIS1: 2,0
			COTA: 1,20
	Ca projetado	3.11	
	Ca Liquido	3,41	
	Gabarito máximo	N/A	
Geral	Total uh	2.154	
	Total de vagas	74 Vagas	

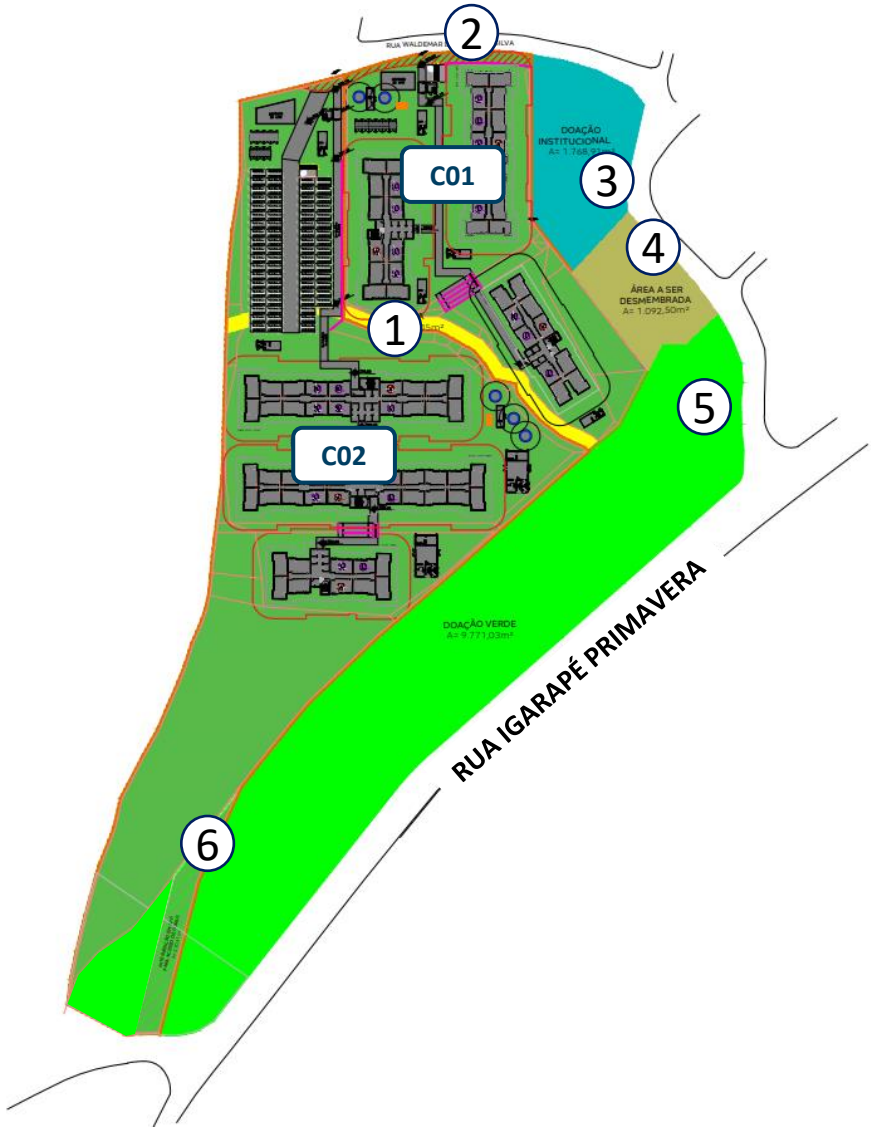

ESTUDO DE MASSA

LEGENDA:

01 FNA Existente
02 Reserva de calçada
03 Doação Institucional
04 Área do proprietário
05 Doação Verde / APP
06 Intervenção em APP

PRODUTO

Travessa Igarapé Primavera
Investimento

	Descrição	Criticidade	Parecer
Usabilidade	**Acesso Empreendimento**	🟢	
	Percurso do pedestre até torre	🟢	
Diferencial produto	**Prime**	Não	
	Supercondomínio	Sim	Condomínio 01 com 1.233uh, não há acesso para divisão em 02 condomínios, Condomínio 02 com 921uh.
	Atributos Infra	Não	
	Atributos Torre	Não	
	Edifício Garagem	Não	

	Considerações	Criticidade	Descrição
Material analisado	KMZ	🟢	
	Mapa Digital da Cidade 2004	🟢	
	Matrícula	🟡	Não foi possível fechar a poligonal com a descrição da matrícula.
	Planialtimétrico	🟢	Levantamento planialtimétrico fornecido por prospecção.
Projeto	Área líquida	🟢	Área irá passar por desmembramento e necessita doação de área institucional, poligonal pode mudar a depender de aprovação mas área líquida para condomínios se mantém
		🟡	Há uma área ocupada pelo proprietário que deverá ser desmembrada e regularizada sendo remanescente para o proprietário.
		🟡	Identificado uma FNA incidindo no terreno, referente a córrego canalizado. A existência da mesma deverá ser confirmada pelo time de legalização.
	Drenagem	🟢	Esta sendo previsto servidão de drenagem do condomínio 02 até a APP.

PRODUTO

Travessa Igarapé Primavera
Investimento

Informações Gerais – Condomínio 01			
Terreno	Área terreno	6.955,47m²	
	Menor poligonal	6.955,47m²	
	FNA	Sim – 384,50m²	
	Área liquida	6.380,47m²	
	Zoneamento	ZEIS-5	
	CA máximo	7,20	ZONA: 4,0
			INCENTIVO HIS1: 2,0
			COTA: 1,20
	CA projetado	4,36	
	Gabarito máximo	N/A	
Geral	Total UH	921	
	Total de vagas	2	
Tipologia	Tipologia	V0200 14PP-LF-C	
	Gabarito	T+25	
	Lâminas	1x 14PP-LF-C | 1x 12PP LF-C | 1x 10PP LN-C	
	Área privativa	32,93m²	
Condomínio	Unidade PCD	28	
	Unidade lazer | técnica	12 | 03	
	Torre	06	
	Fase	Única	
Lazer	Lazer coberto	4x Churrasqueira	
	Lazer descoberto projetado	1.954,37m²	

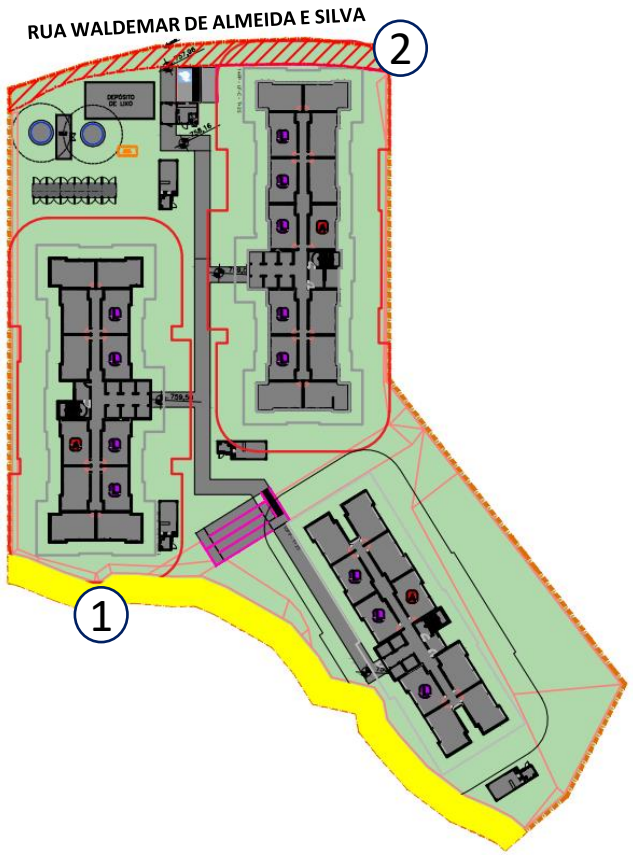

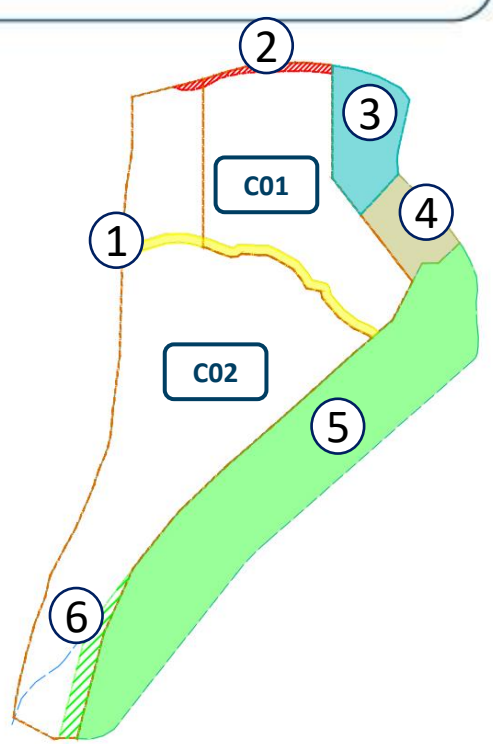

LEGENDA:

01 FNA Existente
02 Reserva de calçada
03 Doação Institucional
04 Área do proprietário
05 Doação Verde / APP
06 Intervenção em APP

ESTUDO DE MASSA

PRODUTO

Travessa Igarapé Primavera
Investimento

Informações Gerais – Condomínio 02			
Terreno	Área terreno	15.759,70m²	
	Menor poligonal	15.759,70m²	
	FNA	Sim – 152,54m²	
	Área liquida	14.404,22m²	
	Zoneamento	ZEIS-5	
	CA máximo	7,20	ZONA: 4,0
			INCENTIVO HIS1: 2,0
			COTA: 1,20
	CA projetado	2,52	
	Gabarito máximo	N/A	
Geral	Total UH	1.233	
	Total de vagas	72	
Tipologia	Tipologia	V0200 20PP-LF-C	
	Gabarito	T+25	
	Lâminas	1x 20PP-LF-C | 1x 18PP LF-C | 1x 10PP LF-C	
	Área privativa	32,93m²	
Condomínio	Unidade PCD	37	
	Unidade lazer | técnica	12 | 03	
	Torre	03	
	Fase	02	
Lazer	Lazer coberto	2x Salão de Festas | 3x Churrasqueira	
	Lazer descoberto projetado	3.069,94m²	

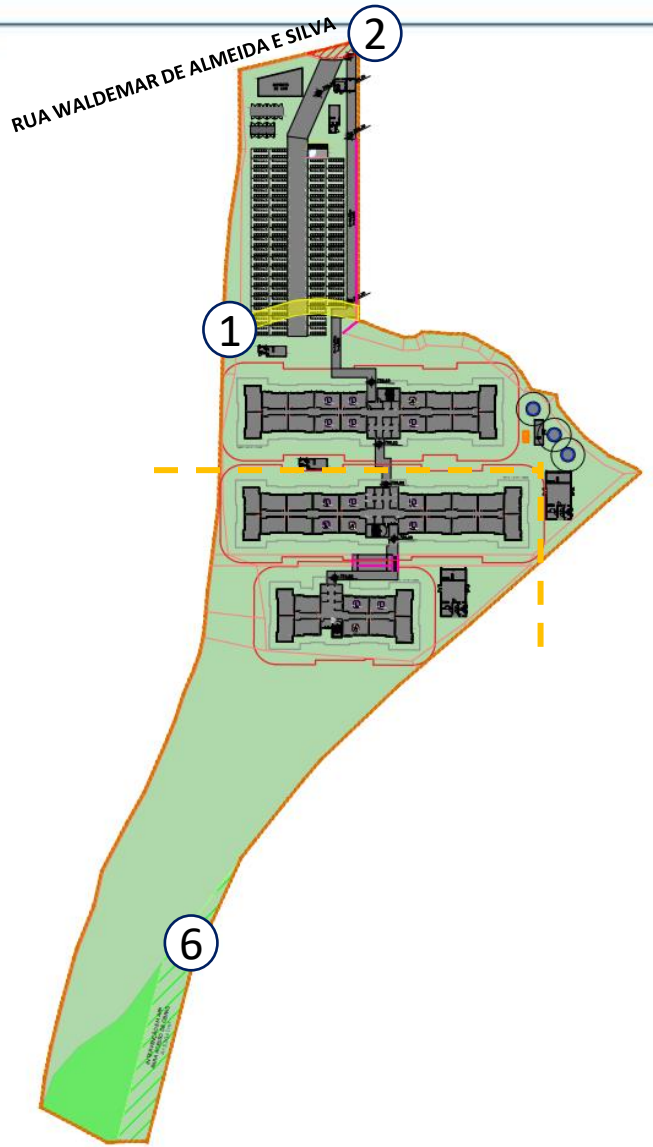

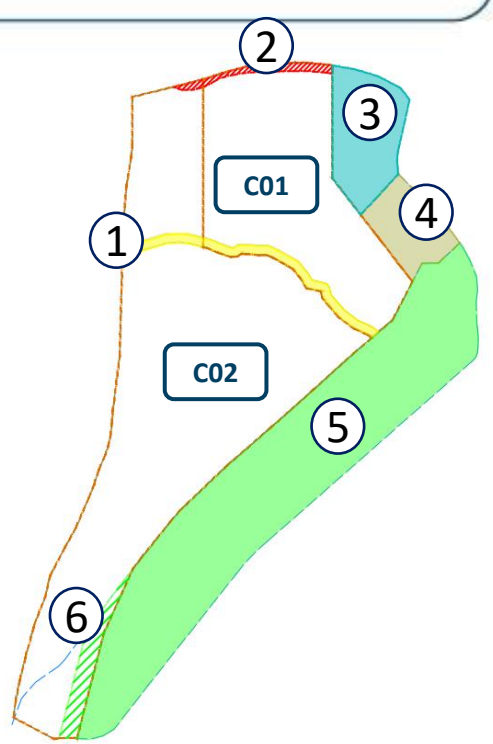

ESTUDO DE MASSA

LEGENDA:

01 FNA Existente
02 Reserva de calçada
03 Doação Institucional
04 Área do proprietário
05 Doação Verde / APP
06 Intervenção em APP

Pareceres

Análise da Mancha e Implantação

Prospecção

Operações

Incorporação

Inteligência de Mercado

Financeiro

Anexos

Condições do Negócio

➢ VALOR DO NEGÓCIO/ CONDIÇÃO COMERCIAL

- 100% em permuta financeira -> 8,5% de permuta bruta com desconto de 12,65%, resultando em uma permuta líquida de 7,4%; estimativa na viabilidade de 40,5MM na permuta Bruta e 35,3MM na permuta líquida;
- O contrato indica uma estimativa de 46,5MM porém sem compromisso ou obrigação além da permuta bruta de 8,5%, e um preço mínimo garantido de 38,0MM sem condição de correção e sem prazo para quitação; como não há correção no PMG, a viabilidade atingirá uma permuta superior ao PMG considerando a inflação;
- OBS: Aproximadamente R$ 538/CA e R$ 1.6773/m2 (ref. base valor terreno no PMG 38MM e cálculo sobre área remanescente).

➢ PRAZOS CONTRATUAIS

- Etapa I: Prazo 120 dias para resolutivas técnica, jurídica e financeira; (previsão set/25)
- Etapa II: Em até 90 dias dias da etapa I para protocolar a regularização dos dados cadastrais do imóvel;
- Etapa III: Em até 18 meses após a superação da Etapa I para os Vendedores promoverem a demolição das construções na APP e a Regularização do contribuinte pela Tenda;
- Etapa IV: Em até 24 meses após superação da Etapa I para aprovação do projeto, obtenção do financiamento CEF e viabilidade técnica e financeira;

A critério da TENDA, podemos suspender os prazos contratuais mediante envio de comunicação por escrito em caso de não superação de qualquer condição resolutiva pelo prazo que for necessário, suspendo as obrigações de pagamento e lavratura da escritura;

➢ PREVISÃO EM CONTRATO DE DESCONTOS DO PREÇO

- 1) Até 10% do valor do negócio para eventual descontaminação; 2) valor que ultrapassar 2 milhões de custo de extensão de rede (Sabesp); 3) eventuais regularizações que se façam necessárias e débitos em aberto

➢ CONDIÇÕES CONTRATUAIS

- Necessidade de desmembramento em dois condomínios;
- Após outorga da escritura do 1º cond., a Tenda terá o prazo de até 36 meses para outorgar a escritura do 2º condomínio ou atingir 90% das vendas, o que ocorrer primeiro;
- Opcionalidade de aquisição do segundo condomínio, podendo desistir a qualquer tempo;
- Possibilidade da Tenda suspender o contrato a qualquer tempo
- Vendedor será responsável por promover a retirada das construções que estão sobre a APP (área de preservação permanente) em até 18 meses da superação da primeira etapa de resolutivas, sob pena de 10% de multa;

➢ GARANTIAS

- Confissão de dívida

➢ CORRETAGEM

- R$ 1.520.0000,00 - 4% sobre o valor do PMG (38MM), parcelados em 6x após outorga da escritura de cada condomínio. Parte da comissão será paga apenas com a outorga da escritura do segundo condomínio, e esse valor será reajustado a partir da outorga da escritura do primeiro condomínio pelo IPCA.

Condições do Negócio

➢ RESOLUTIVAS DO CONTRATO

I - Em até 120 (cento e vinte) dias a contar da assinatura do presente instrumento; (previsão set/25)

i. a existência de ação de desapropriação e/ou declaração de utilidade pública que objetive o Imóvel e/ou Lotes ou parte deles;
ii. a existência de cadastro como Imóvel e/ou Lotes tombado e/ou em processo de tombamento e/ou em áreas envoltórias, no IPHAN, CONDEPHAAT ou CONPRESP, que impossibilitem a adequada consecução do Empreendimento Imobiliário;
iii. a não apresentação da documentação e/ou esclarecimentos indicados nas Cláusulas 3.1, 3.2, 3.2.1 e 3.4 e no ANEXO I pelo VENDEDOR no prazo ali indicado ou a existência de qualquer apontamento nos documentos e certidões forenses que objetive, onerar e/ou possa trazer vício à cadeia dominial do Imóvel e/ou Lotes e/ou possam reduzir o VENDEDOR ao estado de insolvência civil, ou que traga insegurança jurídica na operação objeto deste instrumento, a exclusivo critério da COMPRADORA;
iv. a impossibilidade da realização do estudo de passivo ambiental ou a existência de qualquer tipo de contaminação do solo, subsolo e águas do Imóvel e/ou Lotes, bem como qualquer outro tipo de passivo ambiental e/ou impossibilidade de remoção de árvores que comprometam o Empreendimento que a COMPRADORA pretende desenvolver no Imóvel e/ou Lotes;
v. a existência de óbice e/ou condições técnicas e/ou urbanísticas impeditivas à consecução, no Imóvel e/ou Lotes, do Empreendimento imobiliário almejado pela COMPRADORA;
vi. a não viabilidade das redes de água e esgoto existentes no local, que sejam tidas como insuficientes a garantir a vazão necessária às unidades autônomas que comporão o Empreendimento pretendido;
vii. a não viabilidade de rede elétrica para abastecimento do futuro Empreendimento;
viii. a não viabilidade de execução da drenagem ou não permissão de passagem em terreno de terceiros;
ix. o não aperfeiçoamento de uma ou mais condições resolutivas, relativas ao terreno e ao Empreendimento, abaixo relacionadas:
    - Apuração de condições técnica e eventualmente impeditivas do Imóvel e/ou Lotes;
    - Análise jurídica da documentação do terreno e demais pessoas que serão analisadas, nos termos da cláusula 3.1, supra;
x. caso o gabarito de altura pretendido para o Empreendimento pretendido não seja aprovado no DECEA (Departamento de Controle do Espaço Aéreo) e COMAER (Comando da Aeronáutica);
xi. caso o presente negócio não seja aprovado pelo Comitê de Investimentos da COMPRADORA;
xii. caso seja constatada pela COMPRADORA a existência de terceiros ocupantes no Imóvel e/ou Lotes, existindo pessoas e coisas, que impeçam a transferência da posse para a COMPRADORA de forma inteiramente livre e desimpedida, nos termos previstos no presente instrumento;
xiii. caso o VENDEDOR não logre êxito em promover a abertura e/ou atualização de cadastro junto ao INCRA, CAR, Receita Federal.

Condições do Negócio

➢ RESOLUTIVAS DO CONTRATO

II – Em até 90 (noventa) dias a contar da superação das condições descritas no item "I", supra:

I. a ausência do protocolo, perante a Prefeitura Municipal, objetivando a Regularização do Cadastro Urbano do Imóvel e/ou Lotes, conforme previsto nas Cláusulas 1.3.2 e 1.3.2.1;

III – Em até 18 (dezoito) meses a contar da superação das condições descritas no item "I", supra:

(xvi) Confirmação da demolição e desocupação da Área Construções Consolidadas e/ou de APP pelos ocupantes, promovidos e custeados pelo VENDEDOR.

IV – Em até 24 (vinte e quatro) meses a contar da superação das condições descritas no item "II", supra: ; (previsão CVC dez/27; previsão LEG ago/28)

i. a) a não apresentação da matrícula do Imóvel e/ou Lotes contemplando o destaque da Área Construções Consolidadas; b) caso as partes não logrem promover eventuais regularizações relativas ao Imóvel resultantes do desmembramento, necessárias para a consecução do Empreendimento pretendido; c) a não aprovação do projeto de desmembramento mediante a obtenção das licenças necessárias perante os órgãos competentes; e d) não registro do referido desmembramento na matrícula do Imóvel para abertura das matrículas individualizadas dos Lotes;

ii. a inviabilidade de aprovação nos termos da legislação vigente do projeto do Empreendimento junto à Prefeitura Municipal e demais órgãos competentes, necessários para viabilizar sua edificação, mediante a obtenção de todas as licenças necessárias para tal fim e/ou exigências pela Prefeitura Municipal de obrigações adicionais não contempladas no projeto apresentado e/ou de contrapartida que acarrete a inviabilidade financeira do Empreendimento pretendido pela COMPRADORA;

iii. a inviabilidade de contratação de financiamento pela instituição financeira para construção do Empreendimento, consoante os termos e condições do Programa do Governo Federal Minha Casa Minha Vida, ou qualquer outro programa que venha a substituí-lo, inclusive por força da alteração do cenário jurídico constatado no âmbito da auditoria jurídica anteriormente realizada, a ser novamente verificado por meio da análise dos documentos e certidões em nome do VENDEDOR e dos Lotes atualizados com 30 (trinta) dias de antecedência para a outorga da escritura de compra e venda do de cada um dos Lotes, nos termos da cláusula 3.5, supra;

iv. o não aperfeiçoamento de quaisquer das condições resolutivas, relativas ao terreno e ao Empreendimento, abaixo relacionadas:
   a) Análise da viabilidade técnica e financeira do Empreendimento;
   b) Análise da viabilidade comercial do Empreendimento;
   c) Verificação da manutenção da segurança jurídica, contemplando a análise das certidões do VENDEDOR e do Imóvel e/ou Lotes;

Pareceres

Análise da Mancha e Implantação

Prospecção

Operações

Incorporação

Inteligência de Mercado

Financeiro

Anexos

Custo de Construção CONDOMÍNIO 1 - SIMULADOR

ESTIMATIVA

DADOS DA OBRA		BASES		PRAZOS DE OBRA	
Regional:	SP	Data:	junho-25	Pré Forma:	5,4 meses
Endereço:		Revisão:	R00	Estrutura:	9,5 meses
Total de UH:	**921**	LPU:	LPU 89	Pós Forma:	9,0 meses
Total Torres:	3	LVS:	março-25	**TOTAL:**	**24,0 meses**
Produtos:	F2E Modular	INCC:	1.178,386		
Tipologia:	MODULAR 10PP/12PP/14PP T+25			Jogos de Formas:	2
				Takt:	2+2

CUSTOS DE CONSTRUÇÃO

	CUSTO	R$ / UND
CUSTO TOTAL I	**R$ 90.126.323**	**R$ 98.823**
INDIRETO	R$ 14.856.709	R$ 16.290
TORRE	R$ 51.033.063	R$ 55.957
INFRA	R$ 14.165.012	R$ 15.532
FUNDAÇÃO	R$ 7.599.398	R$ 8.333
ETE	R$ 0	R$ 0
EEE	R$ 0	R$ 0
CONTENÇÃO	R$ 1.022.540	R$ 1.121
TERRAPLENAGEM	R$ 1.449.601	R$ 1.589
CUSTO TOTAL II	**R$ 1.225.000**	**R$ 1.343**
VIÁRIO	R$ 0	R$ 0
DRENAGEM	R$ 0	R$ 0
EXTENSÃO ELÉTRICA	R$ 100.000	R$ 110
EXTENSÃO HIDRÁULICA	R$ 1.125.000	R$ 1.234
CUSTO TOTAL I + II	**R$ 91.351.323**	**R$ 100.166**
CUSTO TOTAL III	**R$ 0**	**R$ 0**
INCORRIDOS NÃO APROVEITADOS	R$ 0	R$ 0
CUSTO TOTAL I A III	**R$ 91.351.323**	**R$ 100.166**
CUSTO TOTAL I A IV	**R$ 91.351.323**	**R$ 100.166**

OBSERVAÇÕES GERAIS

Parâmetro terraplenagem: Nível 3
Parâmetro Contenção: Nível 3

RATEIO FASEAMENTO

Custo de Construção CONDOMÍNIO 2 - SIMULADOR

ESTIMATIVA

DADOS DA OBRA		BASES		PRAZOS DE OBRA	
Regional:	SP	Data:	junho-25	Pré Forma:	5,4 meses
Endereço:		Revisão:	R00	Estrutura:	12,7 meses
Total de UH:	**1.233**	LPU:	LPU 89	Pós Forma:	9,0 meses
Total Torres:	3	LVS:	março-25	**TOTAL:**	**28,0 meses**
Produtos:	F2E Modular	INCC:	1.178,386		
Tipologia:	MODULAR 10PP/16PP T+15			Jogos de Formas:	2
				Takt:	2+2

CUSTOS DE CONSTRUÇÃO

	CUSTO	R$ / UND
CUSTO TOTAL I	**R$ 118.695.143**	**R$ 97.211**
INDIRETO	R$ 18.342.011	R$ 15.022
TORRE	R$ 68.321.136	R$ 55.955
INFRA	R$ 18.548.599	R$ 15.191
FUNDAÇÃO	R$ 10.173.787	R$ 8.332
ETE	R$ 0	R$ 0
EEE	R$ 0	R$ 0
CONTENÇÃO	R$ 1.368.938	R$ 1.121
TERRAPLENAGEM	R$ 1.940.670	R$ 1.589
CUSTO TOTAL II	**R$ 1.225.000**	**R$ 1.003**
VIÁRIO	R$ 0	R$ 0
DRENAGEM	R$ 0	R$ 0
EXTENSÃO ELÉTRICA	R$ 100.000	R$ 82
EXTENSÃO HIDRÁULICA	R$ 1.125.000	R$ 921
CUSTO TOTAL I + II	**R$ 119.920.143**	**R$ 98.215**
CUSTO TOTAL III	**R$ 0**	**R$ 0**
INCORRIDOS NÃO APROVEITADOS	R$ 0	R$ 0
CUSTO TOTAL I A III	**R$ 119.920.143**	**R$ 98.215**
CUSTO TOTAL I A IV	**R$ 119.920.143**	**R$ 98.215**

OBSERVAÇÕES GERAIS

Parâmetro terraplenagem: Nível 3
Parâmetro Contenção: Nível 3

RATEIO FASEAMENTO

DIRETRIZ DE ÁGUA E ESGOTO – SABESP

LIGAÇÃO DE ÁGUA

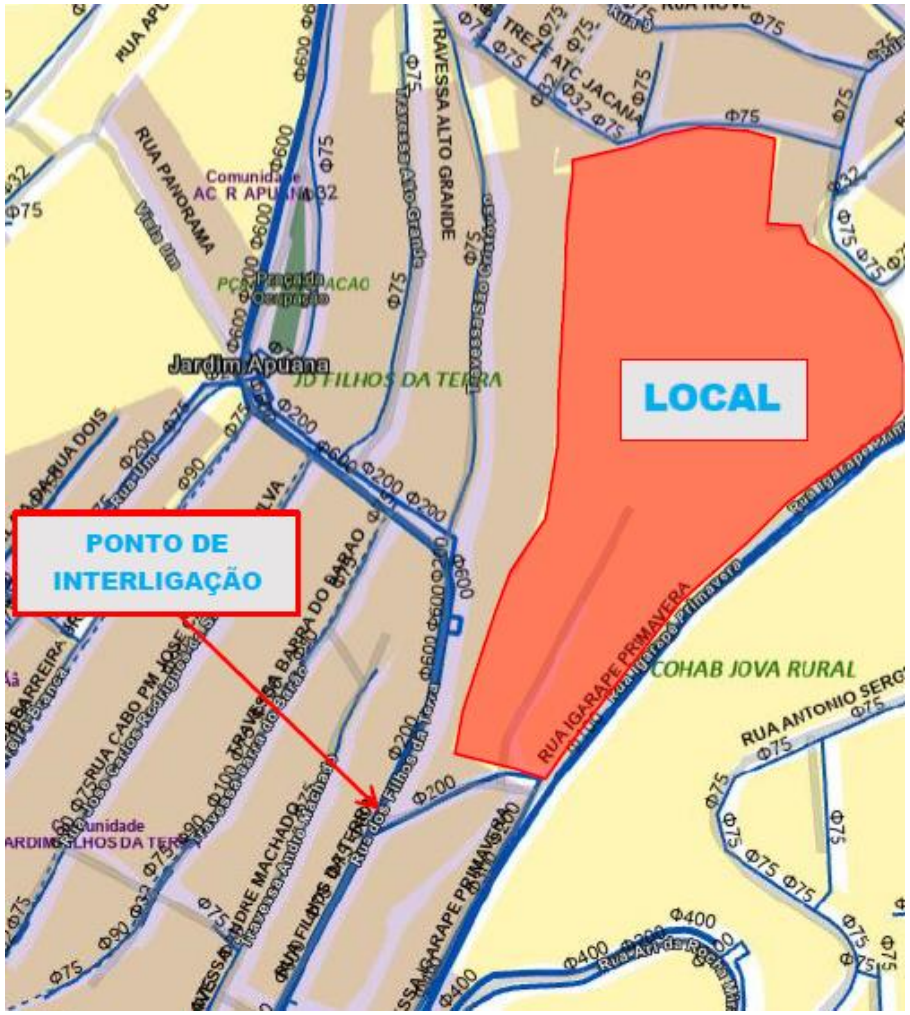

LIGAÇÃO DE ESGOTO

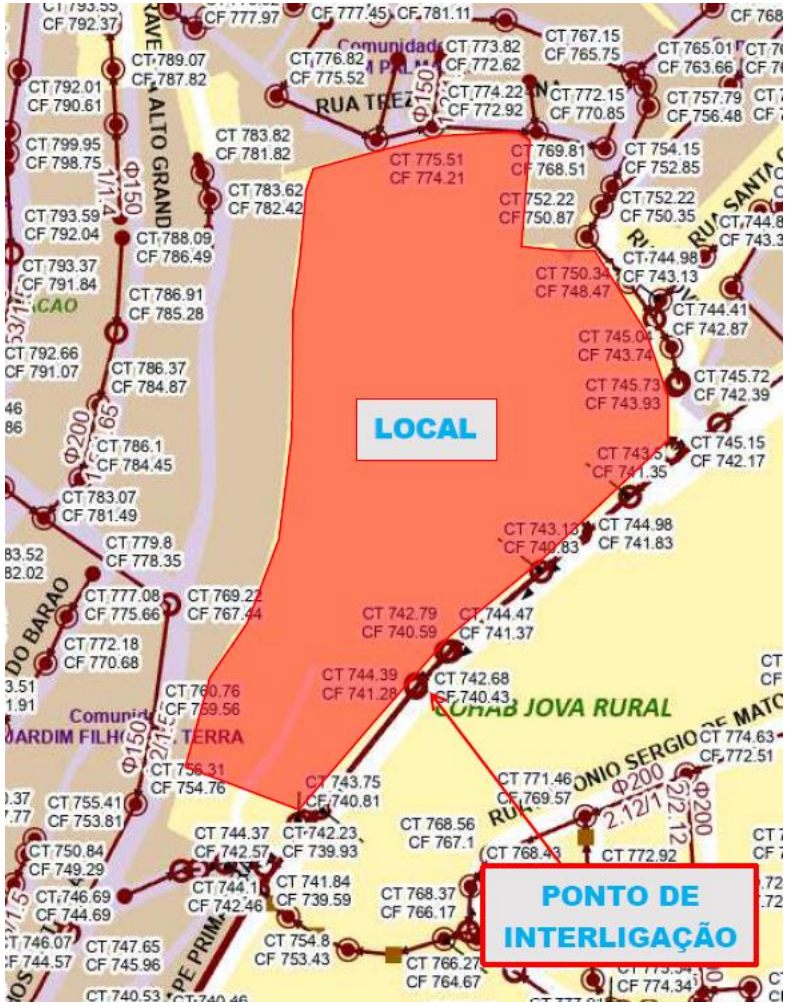

Pareceres

Análise da Mancha e Implantação

Prospecção

Operações

Incorporação

Inteligência de Mercado

Financeiro

Anexos

AMBIENTAL + LEGALIZAÇÃO – Paramétrico de custos

Tenda

REGIONAL SP

PARAMÉTRICO DE CUSTOS LEGALIZAÇÃO

DADOS		QUANDO APLICAR
Quantidade de unidades	2.154	
O Empreendimento terá R2V?	NÃO	
Qual a área do Terreno?	35.323	
Quanto % do terreno Possui árvore?	20%	Se possivel contas arvores, considerar 6m² X quantidade de arvores / area do terreno. Caso não seja possivel, estimar por poligonal
Possível Área Contaminada?	NÃO	Terrenos com histórico de uso industrial anterior; Os vizinhos do entorno podem possuem uso geradores de contaminantes (posto de gasolina, fabricas, gasodutos, etc...);
Esta Cadastrado como Área Possivelmente Contaminada nos Orgão Publicos?	NÃO	Quando no GEOSAMPA estiver classificado como área possivelmente contaminada
Parcelamento do Solo?	C/DOAÇÃO	
Quantos Condomínios?	2	Incluir a quantidade de condomínios que serão gerados no licenciamento

ABERTURA	$ FINAL	MÉTRICA
Compensação Ambiental	R$ 1.500.976	média histórica/ m² de terreno + acrescimo de 30% do valor com aplicação de R2V
Laudos, EIV, EIARIMA	R$ 15.000	15k fixo
Emolumentos e Taxas	R$ 5.000	5k - Revalidação de Certidões + 30k aprovação CETESB (contaminação) quando for classificado como potencialmente contaminado ou existir a possibilidade de ter contaminação;
Assessorias	R$ 5.000	Custas second opinion Ambiental
Cópias, Plotagens, Autenticações, etc...	R$ 15.000	15k fixo
Contra Partida	R$ -	Não temos contrapartida para SP Capital Considerado custas de contaminação/ remediação histórica dos empreendimentos em LB/ m² de terreno
Projeto de criação e Legal	R$ 34.500	1.5k/condomínio de tercerização PL + 4k/condomínio de NBR + 5k complemento plani + 15k para parcelamento do solo (quando houver) + 3.5k para pl grapro (quando houver)
Total	**R$ 1.575.476**	**R$ 731/uh**

CRITÉRIOS DE INPUT DO SIMULADOR

- Considerado 20% da área do terreno com árvores a serem suprimidas, mesmo que visualmente a área de implantação não tenha esse volume. Esse valor previsto para compensação, deverá fazer frente as intervenções em APP e intervenção em FNA que precisaremos para execução da obra e implantação do condomínio;
- Projeto possui desmembramento com doação de área verde e institucional;
- Empreendimento EHIS sem unidades R2v;
- Previsto uma verba de 200k para demolição

JURÍDICO – Paramétrico de custos

REGIONAL SP

PARAMÉTRICO DE CUSTOS JURÍDICO IMOBILIÁRIO

DADOS		QUANDO APLICAR
Quantidade Unidades	2.154	
Área Construída	85.622 m²	
Tem SQL?	NÃO	
Valor do carne de IPTU	R$ -	Considerar sempre o valor do caner de IPTU do ano de aplicação
Área de Matrícula	35.323	
Retificação?	SIM	Quando a matrícula não tiver o encerramento descrito e/ou detalhamento dos perímetro; Quando houver necessária de de acrescimo ou exclusão de áreas do real para implantação do empreendimento;
Quantos Condomínios?	2	
Quantos Proprietários de terreno?	2	
Parcelamento do Solo?	C/DOAÇÃO	C/ Doação: Quando matrícula tiver mais de 20.000m² ou for necessário abertura de mais lotes
Remembramento de Matrículas?	NÃO	Quando a composição do empreendimento é composta por 2 ou mais matrículas para incorporar;
Com qual valor o terreno será escriturado?	R$ 38.000.000	

ABERTURA	$ FINAL	MÉTRICA
Desdobro de IPTU	R$ 5.000	R$ 2.5k/ condomínio
Instituição de Condomínio	R$ 2.692.500	R$ 1250/uh
Averbação da Construção	R$ 647.299	Área Construída(m²) X 4 meses de Cobrança X Índice Histórico (atual 1,79/m²)
Procuração Societária	R$ 5.000	5k fixo
IPTU (Anual)	R$ 63.228	Valor do caner vigente de IPTU ou em caso de não tenha IPTU, considerado para calculo área da matrícula X Índice Histórico (atual 1,79/m²)
Registro de Incorporação	R$ 552.340	R$ 210/uh + 40k quando houver necessidade de retificação
Honorário Incorporação	R$ 316.140	Não gastamos mais com honorários de incorporação Considerado IPTU Retroativo por não ter SQL: $ IPTU X 5 anos
Cópias e Autenticações	R$ 15.000	15k fixo
Honorário Aquisição	R$ 120.000	120k - 2 ou mais prorietários do terreno 80k - 1 proprietário do terreno
Registro de Escritura	R$ 285.000	Valor do terreno X 0,75%
ITBI Terreno	R$ 1.140.000	Valor do terreno X 3%
Total	**R$ 5.841.506**	**R$ 2.712/uh**

CRONOGRAMA PRÉVIO

MÊS	RESP	ETAPA	INÍCIO	FIM	STATUS/ PRAZO (dias)
0	**PROSP**	**COMITÊ INVESTIMENTO ESSENCIAL**	**26/6/25**	**26/6/25**	**-**
	NEG	REUNIÃO PASSAGEM/ PARTIDA	3/7/25	3/7/25	-
	PROSPEC	PLANIALTIMÉTRICO	8/7/25	12/8/25	35
	PROSPEC	FICHA TÉCNICA	17/8/25	16/10/25	30
	NEG	DIRETRIZ SABESP	18/7/25	1/9/25	45
	PRÉ-LEG	INVESTIGAÇÃO AMBIENTAL	13/7/25	10/11/25	120
	DPP	ELABORAÇÃO AP	1/9/25	21/9/25	20
	CUSTOS	PARAMETRIZAÇÃO	6/10/25	26/10/25	20
	NEG	CONFIRMAÇÃO FINANCEIRA	31/10/25	10/11/25	10
6	**NEG**	**COMITÊ INVESTIMENTO AMPLIADO**	**30/12/25**	**30/12/25**	**-**
	GETEC	ELABORAÇÃO PROJETO SABESP	28/9/25	26/1/26	120
	GETEC	APROVAÇÃO SABESP	2/2/26	2/6/26	120
	PL	ELABORAÇÃO PL (DIRETRIZES)	11/10/25	25/11/25	45
	LEG	CERTIDÃO DE DIRETRIZES	2/12/25	2/12/26	365
	PL	ELABORAÇÃO PL (DESMEMBRAMENTO)	2/11/26	2/12/26	30
	JUR	MATERIAL DE REGULARIZAÇÃO	21/10/25	20/11/25	30
	JUR	CERTIFICADO DE REGULARIZAÇÃO	27/11/25	27/11/26	365
	LEG	ALVARÁ DE DESMEMBRAMENTO	7/12/26	31/5/27	180
	PROSP	DEMOLIÇÃO DAS AREAS CONSTRUÍDAS IRREGULAR	27/12/26	25/2/27	60
	JUR	REGISTRO DE DESMEMBRAMENTO	10/6/27	9/8/27	60
	GETEC	ENGENHARIA SIMULTÂNEA	22/12/26	5/2/27	45
	GETEC	EP KIT LEGAL	6/2/27	11/6/27	120
	PL	ELABORAÇÃO PL (CONDOMÍNIOS)	10/6/27	25/7/27	45
	LEG	CETESB (CONTAMINADO)	25/11/25	24/5/26	180
	LEG	ALVARÁ DE APROVAÇÃO E EXECUÇÃO	16/8/27	12/5/28	270
	LEG	ANÁLISE DE GRAPROHAB	13/3/28	11/7/28	180
	NEG	**COMITÊ DE ESCRITURA/ LANÇAMENTO**	**18/7/28**	**18/7/28**	**-**
	JRI	ESCRITURA	21/7/28	20/8/28	30
	JRI	REGISTRO INCORPORAÇÃO	21/8/28	20/9/28	30
	CRD	LAUDOS CEF	4/7/28	2/10/28	90
40	**NEG**	**LANÇAMENTO**	**2/10/28**	**2/10/28**	**-**

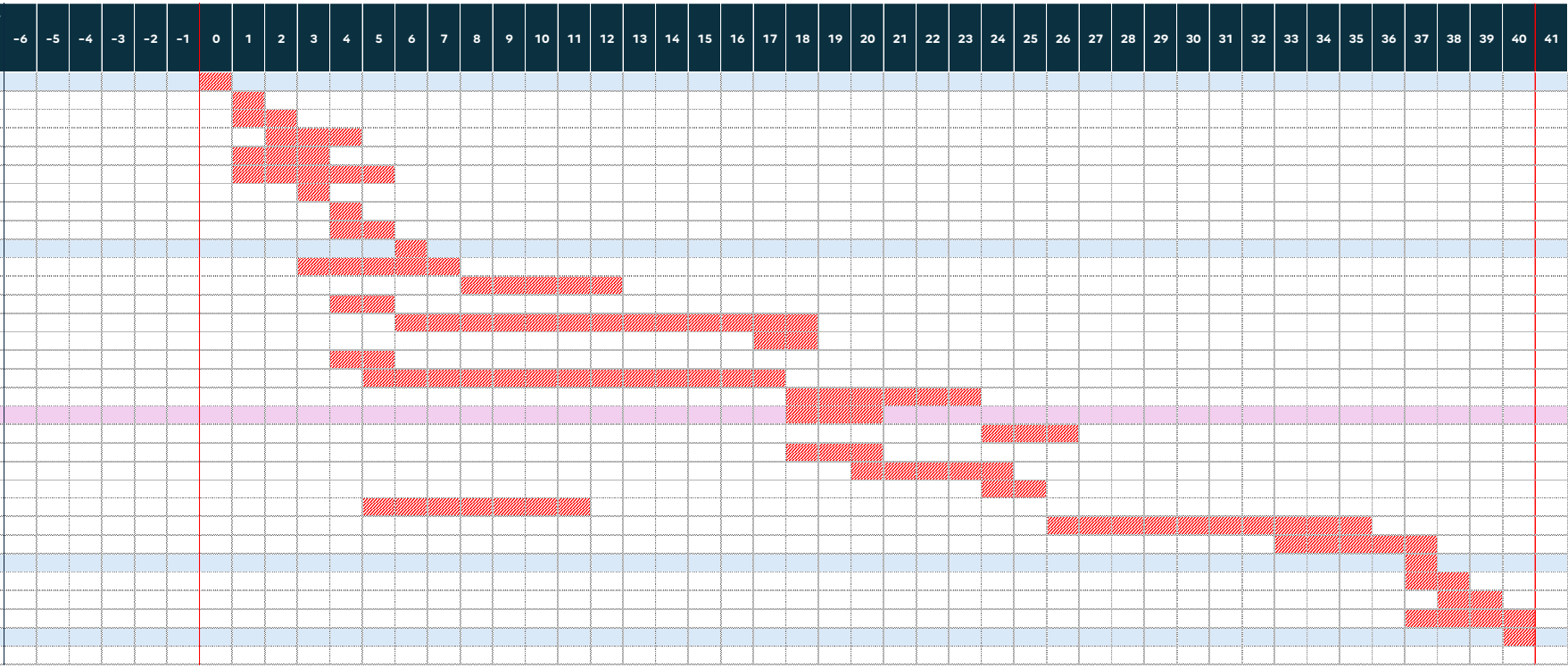

Pareceres

Análise da Mancha e Implantação

Prospecção

Operações

Incorporação

Inteligência de Mercado

Financeiro

Anexos

Demanda e Distribuição da Mancha

Potencial de Demanda			Lançados		Lançados + Landbank	
Mancha	CÓD.	Shr.	ANO	MÊS	ANO	MÊS
São Paulo Norte	SZN	27%	1.505	125	1.806	150

Empreendimento	Renda	Lançamento	out/28	nov/28	dez/28	jan/29	fev/29	#####	abr/29	mai/29	jun/29	jul/29	ago/29	set/29	out/29	nov/29	dez/29	jan/30	fev/30	#####	abr/30	mai/30	jun/30	jul/30
Monte Trindade	**2.796**	**mar-27**																						
Bela Vista Jaragua - F2	2.958	mar-28	26	26	26	26	26	26	26	26	26	26	26	19										
Spazzio Primavera	**3.380**	**out-28**		**51**	**51**	**51**	**51**	**51**	**51**	**51**	**51**	**51**	**51**	**51**	**51**	**51**	**51**	**51**	**51**	**51**	**51**			
Spazzio Primavera - F2	**3.380**	**abr-30**																			**22**	**22**	**22**	**22**
Spazzio Primavera - F3	**3.380**	**out-31**																						
Parque Anhanguera F1 (Nilo Cairo)	3.068	mai-29									34	34	34	34	34	34	34	34	34	34	34	34	34	34
Chácara Pirituba - Amanhecer	2.809	ago-29												31	31	31	31	31	31	31	31	31	31	31
Total de Vendas Lançados			**0**	**0**	**0**	**0**	**0**	**0**	**0**	**0**	**0**	**0**	**0**	**0**	**0**	**0**	**0**	**0**	**0**	**0**	**0**	**0**	**0**	**0**
Total de Vendas Lançados + Landbank			**26**	**77**	**77**	**77**	**77**	**77**	**77**	**77**	**111**	**111**	**111**	**135**	**116**	**116**	**116**	**87**	**87**	**87**	**87**	**87**	**87**	**87**

Parecer de I.M sobre a mancha:

O projeto analisado em comitê está em linha com o potencial teórico de demanda calculado para a mancha. (Total Lanç + Landbank)

Canibalização:

Sem Risco de Canibalização

Spazzio Primavera | Mapa Concorrência

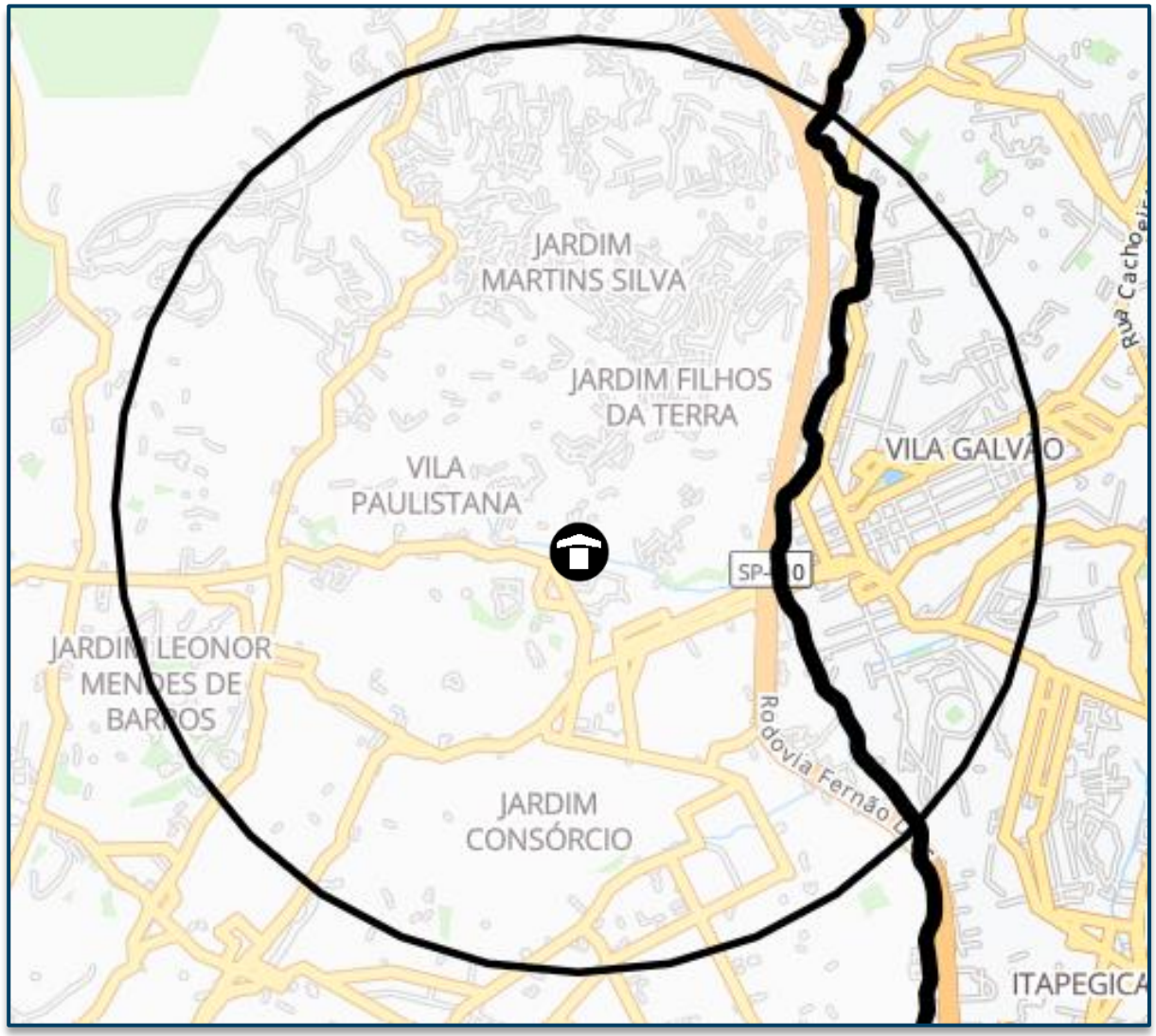

Diagnóstico Concorrência

- Não temos projetos na região com estoque performando no Faixa 2, a Plano & Plano irá lançar o projeto Plano & Jaçanã em breve, mas não temos informações a respeito de preço e renda.

		Spazzio Primavera
		TENDA
Região 1 Km	População	57.363
	Dens. Demográfica	18.377
	Renda (R$)	4.940
	Classe Social	C1 (2.7k a 4.6k)
	PEA Dia	21.624

Farol Renda
Acima de 300
Entre 0 e 300
Abaixo de 0

Simulação de Preço

Informações Viabilidade

Projeto:	Spazzio Primavera	
Tipo:	**HMP**	
Método	**Vision**	
Avaliação	225.000	
Renda Inicial (VF)	3.380	
Renda Final*	-	
% RET1	25%	
Tipo:	**VF**	**R$**
Ato	0,69	2.303
FGTS	0,67	2.263
Financiamento	97,21%	169.493
Subsídio	124,67%	4.595
Prazo de Pró-soluto	29	29
Pró-Soluto	62,87%	22.391
Preço Raso (RS)	201.046	201.046
TCD	49,58%	16.891
VSO	51	51
Preço de Venda	**219.430**	**219.430**
Elasticidade	-0,680%	-0,680%
Preço de Venda Final	**217.937**	**217.937**
Preço Raso (R$)	**201.046**	
% de Raso	**92,25%**	
BP25 - Não Inflacionado	**-**	
BP25 - Inflacionado	**-**	

Análise de Preço

Informações Viabilidade

Projeto:	Spazzio Primavera
Tipo:	**Faixa 2**
Método	**Vision**
Avaliação	225.000
Renda Inicial (VF)	3.380
Renda Final*	-

Tipo:	VF	R$
Ato	0,69	2.303
FGTS	0,67	2.263
Financiamento	97,21%	169.493
Subsídio	124,67%	4.595
Prazo de Pró-soluto	29	29
Pró-Soluto	62,87%	22.391
Preço Raso (RS)	201.046	201.046
TCD	49,58%	16.891
VSO	51	51
Preço de Venda	**219.420**	**219.420**
Elasticidade	-0,680%	-0,680%
Preço de Venda Final	**217.937**	**217.937**
Preço Raso (R$)	**201.046**	
% de Raso	**92,25%**	
Raso Todas as Fases	**204.180**	
Nominal Todas as Fases	**220.996**	

1

Análise de Riscos	Farol IM
IM avalia o Preço Vision como **factível**.	

1) I.M está de acordo com o preço Vision, tendo em vista que, o projeto está em uma região com bons indicadores sociodemográficos e onde já capturamos rendas próximas ao estimado pelo Vision no projeto Portal do Parque, que atualmente não tem mais estoque relevante.

Conforme consta no slide "Panorama de Concorrência", não localizamos projetos no Faixa 2 – MCMV.

	Preço Real					Preço Normalizado (29m)	
	Avaliação	Preço Raso	Renda Média	VSO	PSOL	Δ PSOL	Preço Raso
Portal do Parque	221.411	194.459	3.222	50	21	7.248	201.707
Spazzio Primavera	225.000	201.046	3.380	51	29	-	201.046
Farol Cantareira	223.024	192.951	3.403	17	18	13.202	206.153
Viva City Jaraguá	223.201	193.336	3.584	27	13	19.024	212.360
Parque Limão	240.120	217.010	3.800	60	20	10.584	227.594
Melodia Jaçanã	253.372	241.392	4.400	83	33	-4.756	236.636

Simulação de Preço – Fases Futuras

Vision

Nome Fase	Tipologia	Renda	Ato	FGTS	Cond.	Subsídio	PSOL	TCD	VSO	Nom. Pré	Avali.	Elast.	Nom. Pós	Raso Pós	PSOL (m)	RET1
Spazzio Primavera - F2	Sem Vaga	3.380	0,69	0,67	96,0%	124,7%	63,3%	49,9%	18	222.539	225.000	0,00%	222.539	205.532	33	25%
Spazzio Primavera - F2	Com Vaga	3.888	0,60	0,59	99,1%	86,2%	63,3%	32,5%	4	235.427	245.000	0,00%	235.427	222.700	33	0%
Spazzio Primavera - F3	Sem Vaga	3.380	0,69	0,67	96,0%	124,7%	63,3%	49,9%	20	222.539	225.000	0,00%	222.539	205.532	33	25%

Ciclo Financeiro – Análise Mancha

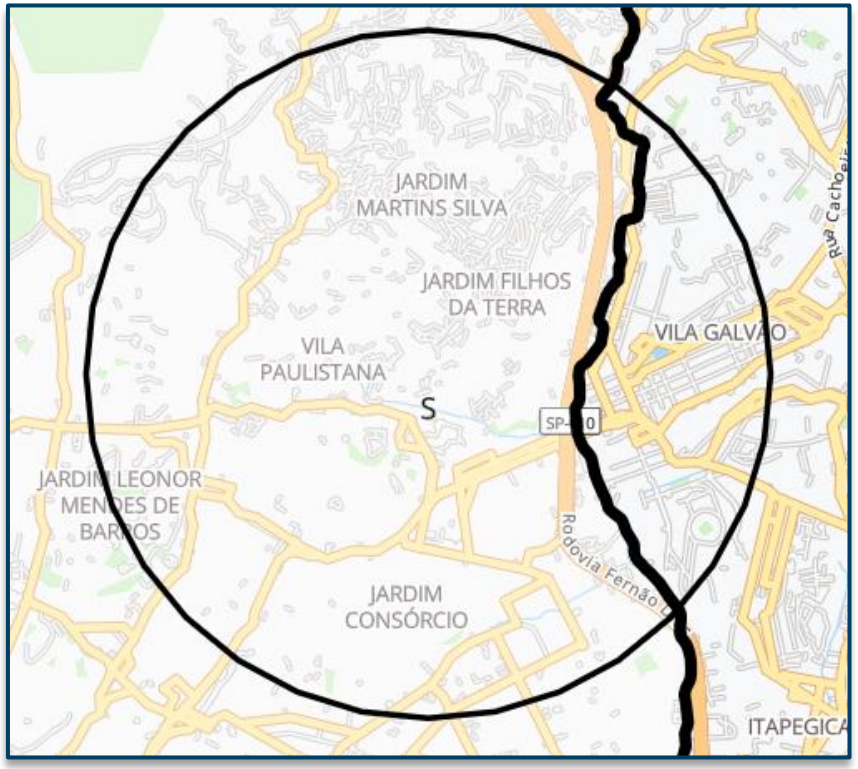

Parecer Ciclo

O Ciclo avaliou o preço e o VSO como factíveis. O projeto está localizado em uma região estratégica e com grande potencial, próxima ao lançamento Melodia Jaçanã. No entanto, encontra-se em uma microrregião inferior.

Em junho, a Plano divulgou no Meeting o *Plano&Jaçanã*, concorrente direto do Melodia Jaçanã, voltado para famílias de renda média acima do Spazio Primavera. As unidades variam entre apartamentos com varanda sem vaga (renda média R$ 5.500, a partir de R$ 249.900) e varanda com vaga (renda média R$ 6.900, a partir de R$ 309.900).

Apesar dessa concorrência, o Spazio Primavera se posiciona para um público diferente, com foco na demanda específica de sua região de inserção.

Pareceres

Análise da Mancha e Implantação

Prospecção

Operações

Incorporação

Inteligência de Mercado

Financeiro

Anexos

Informações Financeiras

Spazio Primavera - SP - São Paulo Capital

Datas e Prazos

	Compra	Lançamento	Início Obra	Término Obra	LÇTO até IO	IO até TO	Chaves	LÇTO até Chaves
Consolidado	jun-25							
Cond 1 - Fase 1		out-28	abr-29	abr-31	6 meses	24 meses	out-31	36 meses
Cond 2 - Fase 1 s/ vaga		abr-30	out-30	fev-33	6 meses	28 meses	abr-33	36 meses
Cond 2 - Fase 1 c/ vaga		abr-30	out-30	fev-33	6 meses	28 meses	abr-33	36 meses
Cond 2 - Fase 2		out-31	abr-32	ago-34	6 meses	28 meses	out-34	36 meses

Terreno e Incorridos

TOTAL (R$ + Perm.):	40,46 MM	**Incorrido Terreno:** 0,00 MM	**Área do Terreno (100%):**	35.349 m²	**Área Líquida do Terreno:** 20.785 m²
Cash:	0,00 MM		**Custo de terreno m²:**	1.144,7	**Custo de terreno m² Área Líquida:** 1.946,7
Permuta Financeira:	40,46 MM (8,50%)		**VaR 25 (R$ mil):**	0	**Fração Terreno/Terreno + Custo Obra (%VGV):** 8,5% / 53,3%
Permuta Física:	0,00 MM (0,00%)		**VaR 26 (R$ mil):**	0	**CA Máx/Proj.** 7,2 / 3,4
Ato / %VGV:	0,00 MM / 0,0%		**Incorrido de Construção:**	0,00 MM	**Incorridos de Incorporação:** 0,00 MM

Vendas

Fases	Nº Pavimentos	Preço Raso Unit.	Qtde	Preço Unit.	Aval. CEF	Cond. Parcela	% Pró-soluto	% TCD
Cond 1 - Fase 1	T+22	201.046	921	217.937	225.000	97,2%	62,9%	49,6%
Cond 2 - Fase 1 s/ vaga	T+22	205.532	391	222.539	225.000	96,0%	63,3%	49,9%
Cond 2 - Fase 1 c/ vaga	T+22	222.700	71	235.427	245.000	99,1%	63,3%	32,5%
Cond 2 - Fase 2	T+22	205.532	771	222.539	225.000	96,0%	63,3%	49,9%

Unidades Totais:	2.154	**Preço Médio:**	220.996	**Renda Média:**	3.397	**ITBI+Emol. Unit. Médio:**	2.518
Unidades Tenda:	2.154	**Avaliação Média:**	225.659	**Ato:**	2.320 (0,68 Salários)	**Custo do Ciclo Unit.:**	13.911
VSO:	30 Unidades	**VGV Total:**	476.026.071	**FGTS:**	2.280 (0,67 Salários)	**Preço Raso Médio:**	204.180
RET Médio:	3,3%	**VGV Tenda:**	476.026.071	**% em RET 1%:**	24%	**Adc. Tx. de Aceleração Médio:**	750

Construção

Custo Total Unit. | Corrigido:	99.049 | 99.559	**Eventuais:**	4,00%	**Área priv (m²):**	32,00	**Gape / Mês Unit.:**	11,08

Resultado

LI (R$):	**40.352.886**	**LI:**	**21,28%**	**Exposição de Caixa (R$):**	**20.389.747**	**Margem Bruta Econômica:**	**38,00%**
TIR:	**143,86%**	**LI Aprovação:**	**20,00%**	**Ger. Caixa 12 meses (R$):**	**0**	**Margem Bruta REF:**	**40,91%**
Exposição de Caixa:	**3,37%**	**Δ LI:**	**1,28%**	**Ger. Caixa 24 meses (R$):**	**0**	**Margem Rasa Econômica:**	**32,18%**
Payback Contingente (21 m):	**19 m/ (-2 m)**	**LI Resiliência:**	**7,81%**	**Ger. Caixa Marginal (R$):**	**153.963.064**	**Margem Rasa REF:**	**36,05%**
Payback Consolidado:	**19 meses**					**Margem de Contribuição Econômica:**	**27,40%**

Informações Financeiras

R$ Mil - Valores Nominais - Compra	Tv Igarape		Cond 1 - Fase 1		Cond 2 - Fase 1 s/ vaga		Cond 2 - Fase 1 c/ vaga		Cond 2 - Fase 2	
	Nominal	%	Nominal	%	Nominal	%	Nominal	%	Nominal	%
Receita	605.254	100,0%	237.465	100,0%	111.037	100,0%	21.221	100,0%	235.532	100,0%
PIS/COFINS	(10.875)	1,8%	(4.232)	1,8%	(1.979)	1,8%	(465)	2,2%	(4.198)	1,8%
Custo Total	(368.485)	62,0%	(147.363)	63,2%	(66.991)	61,4%	(12.266)	59,1%	(141.866)	61,3%
Custo Terreno	(44.939)	7,6%	(17.631)	7,6%	(8.244)	7,6%	(1.576)	7,6%	(17.488)	7,6%
Custo Relacionados a Terreno	(1.973)	0,3%	(822)	0,4%	(360)	0,3%	(68)	0,3%	(722)	0,3%
Custos de Incorporação	(12.009)	2,0%	(4.713)	2,0%	(2.233)	2,0%	(425)	2,0%	(4.638)	2,0%
Custo de Construção	(309.565)	52,1%	(124.197)	53,3%	(56.153)	51,5%	(10.197)	49,1%	(119.018)	51,4%
Lucro Bruto Econômico	225.894	38,0%	85.869	36,8%	42.067	38,6%	8.490	40,9%	89.468	38,7%
Custo para Rateio	-	0,0%	-	0,0%	-	0,0%	-	0,0%	-	0,0%
Lucro Bruto Contábil	225.894	38,0%	85.869	36,8%	42.067	38,6%	8.490	40,9%	89.468	38,7%
Despesas de Selling	(49.112)	8,3%	(19.276)	8,3%	(9.003)	8,3%	(1.730)	8,3%	(19.103)	8,3%
Contingência	(13.921)	2,3%	(5.462)	2,3%	(2.554)	2,3%	(488)	2,4%	(5.417)	2,3%
Margem de Contribuição	162.861	27,4%	61.131	26,2%	30.511	28,0%	6.271	30,2%	64.948	28,1%
IR e CSLL	(8.897)	1,5%	(3.463)	1,5%	(1.619)	1,5%	(381)	1,8%	(3.435)	1,5%
Margem Líquida	153.963	25,9%	57.668	24,7%	28.891	26,5%	5.890	28,4%	61.513	26,6%
Lucro Bruto REF Unit.	117.039	40,9%	105.113	39,9%	119.890	41,4%	135.560	44,2%	129.197	41,4%
Lucro Raso REF Unit.	95.235	36,1%	84.697	34,8%	97.781	36,5%	119.027	41,1%	105.405	36,6%

R$ Mil - VPL - Compra	Tv Igarape		Cond 1 - Fase 1		Cond 2 - Fase 1 s/ vaga		Cond 2 - Fase 1 c/ vaga		Cond 2 - Fase 2	
	VP	%	VP	%	VP	%	VP	%	VP	%
Receitas	189.645	100,0%	95.456	100,0%	33.358	100,0%	6.426	100,0%	54.405	100,0%
PIS/COFINS	(3.355)	1,8%	(1.676)	1,8%	(586)	1,8%	(139)	2,2%	(955)	1,8%
Custos e Despesas Totais	(145.937)	77,0%	(74.107)	77,6%	(25.415)	76,2%	(4.717)	73,4%	(41.698)	76,6%
Custo Terreno	(13.478)	7,1%	(6.784)	7,1%	(2.371)	7,1%	(457)	7,1%	(3.867)	7,1%
Custo Relacionados a Terreno	(1.088)	0,6%	(454)	0,5%	(199)	0,6%	(38)	0,6%	(398)	0,7%
Custos de Incorporação	(4.476)	2,4%	(2.109)	2,2%	(812)	2,4%	(156)	2,4%	(1.400)	2,6%
Custo de Construção	(103.050)	54,3%	(52.892)	55,4%	(17.799)	53,4%	(3.232)	50,3%	(29.127)	53,5%
Despesas de Selling	(18.922)	10,0%	(9.386)	9,8%	(3.378)	10,1%	(649)	10,1%	(5.509)	10,1%
Contingência	(2.178)	1,1%	(1.112)	1,2%	(378)	1,1%	(72)	1,1%	(616)	1,1%
IR e CSLL	(2.745)	1,4%	(1.371)	1,4%	(479)	1,4%	(114)	1,8%	(781)	1,4%
Lucro Imobiliário	40.353	21,3%	19.673	20,6%	7.358	22,1%	1.570	24,4%	11.752	21,6%

Pareceres

Análise da Mancha e Implantação

Prospecção

Operações

Incorporação

Inteligência de Mercado

Financeiro

Anexos

PARECER PRÉVIO – Jurídico Imobiliário

- **DESCRIÇÃO DO IMÓVEL:** Terreno situado à Travessa Igarapé Primavera nº 92, objeto da matrícula nº 264.050 do 15º Oficial de Registro de Imóveis de São Paulo/SP, cadastrado junto ao INCRA sob nº 9500760909640 ("**Imóvel**").

- **PROPRIETÁRIO TABULAR: PAULO ROBERTO DOS SANTOS**

- **CONSIDERAÇÕES JURÍDICAS SOBRE O IMÓVEL: (a) Retificação:** Será analisado a necessidade em retificar a área, no ato da contratação de profissional capacitado para a realização de estudos técnicos; **(b) Loteamento:** Providenciaremos as certidões do imóvel até a origem (transcrição) para verificarmos se o imóvel atual foi objeto de loteamento no passado e em caso positivo verificaremos eventuais restrições; **(c) Desmembramento:** Imóvel objeto de aquisição será desdobrado em duas áreas para as construções de dois empreendimentos distintos; **(d) Área construída:** Não consta área construída averbada na matrícula, porém fisicamente no local há construções objeto de regularização; **(e) Ocupação:** Atualmente é ocupado por construções consolidadas por terceiros, inclusive em área de APP, cuja a desocupação será providenciada, sendo de única e exclusiva responsabilidade do vendedor, a ser firmado em Aditamento contratual; **(e) Débitos Imobiliários:** Não constam débitos imobiliários, diante da ausência de cadastro junto ao município, no entanto após a abertura de contribuinte municipal existe a possibilidade do município lançar retroativo dos últimos 5 anos, cujo o vendedor será o único responsável por efetuar os devidos pagamentos. Embora o imóvel tenha cadastro junto ao INCRA, será necessário a regularização dos cadastros rurais junto ao INCRA, RF e CAR e eventuais débitos retroativos serão de responsabilidade do vendedor; **(f) Multas, Desapropriação e Melhoramentos:** Serão apurados em Due Diligence; **(g) Ônus e Gravames**: Consta na Av-02 da matrícula averbação de premonitória, referente a Ação de Cumprimento de Sentença, a qual deve ser cancelada conforme baixa de penhora já prevista na matrícula; **(h) Função Social da Propriedade:** Considerando que há ocupação no imóvel, a função social está sendo cumprida, nos termos da Constituição Federal.

- **CONSIDERAÇÕES AUDITORIA PRÉVIA – PROPRIETÁRIO TABULAR:**

- **A) PAULO ROBERTO DOS SANTOS**

1. **Tributos Mobiliários**: débitos relacionados ao Imóvel R. Luis de Oliveira Bulhões 00090, sem valor indicado na certidão, necessário esclarecimentos do proprietário;
2. **Processo:** 1009604-96.2022.8.26.0001 - Notificação para Constituição em Mora - Valor atualizado até 10/06: **R$ 25.021,97**
3. **Processo**: 000004009-41.2021.8.26.0090 - Rescisão de Contrato c/c devolução de valores (gravame Av-02) - Valor de Causa: **R$ 119.877,10**
4. **Processo:** 0021532-72.2024.8.26.0007 - Incidente de Desconsideração da Personalidade Jurídica decorrente de condenação em ação de indenização por acidente de consumo, decorrente de contrato de transporte coletivo de passageiros – Valor atualizado até 10/06: **R$ 6.480,72**;

Com relação ao proprietário tabular, embora ainda não haja confirmação inequívoca quanto a sua identidade, dos processos em que consta como réu, diante da ausência de identificação (RG e CPF) nos processos, cogita-se a possibilidade de homonímia. Todavia, não se pode descartar, neste momento, a hipótese de que se trate efetivamente do Sr. Paulo Roberto dos Santos. Assim, eventual confirmação será oportunamente realizada no curso da Due Diligence, por meio de análise minuciosa dos autos dos processos judiciais relacionados.

11 processos – possível homônimo: inexistência de parâmetros informados - risco "baixo";
18 processos – possível homônimo: em segredo de justiça - risco "moderado";
45 processos – possível homônimo: em segredo de justiça - risco "baixo";

- **CONCLUSÃO.:** Atualmente é ocupado por construções consolidadas por terceiros, cuja a desocupação será providenciada pelo vendedor, apresentando instrumento constando a desocupação do imóvel e a imediata demolição das construções existentes e liberação da APP, bem como a implementação de vigilância contínua, de forma a garantir a segurança do imóvel e prevenir novas invasões.
No tocante aos processos localizados que são de possível homônimo, e que não são segredo de justiça estamos realizando o levantamento e os em segredo de justiça, solicitamos esclarecimentos ao proprietário.
Em relação ao processo no valor de R$ 119.877,10, foi realizada a baixa da penhora na matrícula, restando pendente somente o cancelamento da premonitória, não havendo risco para a aquisição.

PARECER PRÉVIO – Legalização

➢ **ÁREA DE IMPLANTAÇÃO**

- O terreno é composto por 1 matrícula do 15º CRI), em nome de Paulo Roberto dos Santos (pessoa física), que totaliza uma área escriturária de 35.322,90m²;
- O cadastro do imóvel é rural;
- O cenário foi desenvolvido sobre a poligonal do planialtimétrico, definida 35.384,53m²;
- Travessa Igarapé Primavera, conforme geosampa, possui 10,50m. Travessa Waldemar de Almeida e Silva e Rua Nove possuem entre 7,00 e 8,00m de largura.

➢ **DIRETRIZES URBANÍSTICAS**

- O terreno esta inserido em ZEIS-2 e ZEIS-5, conforme decreto 63.728/2024:
    - C.A. máximo: 4,00 para EHIS, 4,00 para EHMP, sem restrição de gabarito, TO 70% e PA 10, necessário reserva de calçada para atingir os 5,00m.
- Terreno será parcelado em 02 condomínios, em função da área do terreno ser superior a 20.000m² e há obrigatoriedade de doação de áreas públicas.
- O estudo considera implantação de 2 condomínios, sendo:
    - C01: 3 torres sendo 1x20PP, 1x18PP e 1x10PP, T+25 e, com 1.233 UH – CA 2,57
    - C02: 3 torres sendo 1x14PP, 1x12PP e 1x10PP, T+25 e, com 845 UH – CA 4,00 + 0,36 de benefício (76 Unidades HIS-1)
- Em função do zoneamento não é exigido cota a parte;
- A legislação não exige vaga de garagem, porém foram consideradas 71 vagas comuns e 1 vaga PNE no condomínio 01;
- Usos permitidos: EHIS e EHMP.

➢ **GRAPROHAB**

- Numero de UH do estudo (EM) supera o 800 UH, sendo necessário a aprovação;

➢ AVALIAÇÕES AMBIENTAIS

Arbóreo

- Conforme consulta ao GeoSampa, o terreno **não** é considerado como Patrimônio Ambiental
- Temos incidência de APP sobre o terreno;
- Necessário laudo arbóreo;
- Para cenário de comitê, conforme parametrização enviada, foi considerado XX% de incidência arbórea.
- A propriedade não está inserida em Área de Patrimônio Ambiental (APA), Área de Proteção de Mananciais (APRM) e Unidade de Conservação;
- Cenário considera a supressão de todos os exemplares localizados no interior do lote;
- Compensação de 1:10 (HIS e HMP), para cenário R2v seguir legislação;

Hidrografia

- O Imóvel apresenta corpos d'água internos ao perímetro e próximo;
- Córrego mais próximo está inserido do imóvel, gerando APP de 30m.;

➢ AVALIAÇÕES AMBIENTAIS

Contaminação (Contaminado)

1- Conforme consulta ao GeoGegran o terreno não é objeto de contaminação;

Para efeito de comitê essencial foi considerado o terreno como contaminado, pois o espaço é utilizado como estacionamento de carros e possui, conforme observado em algumas imagens do relatório fotográfico do planialtimétrico, locais com manchas no solo e acúmulo de lixo, bem como tem alguns canos de vizinhos que escoam para o terreno.

PARECER PRÉVIO – Legalização

- **ÓRGÃOS DE PATRIMÔNIO HISTÓRICO**
- De acordo com a certidão CIT, o imóvel é isento de aprovação perante ao CONPRESP, CONDEPHAAT, UPPH e DPH;
- **DRENAGEM**
- Lançamento da drenagem no córrego dentro do terreno. Será necessária a aprovação de intervenção em APP;

- **URBANIZAÇÃO**
- Não consta DUP/DIS ou ação visando a desapropriação do imóvel, bem como o mesmo não é atingido por plano de melhoramento viário ou sanitários;
- Conforme croqui patrimonial, não consta área pública no imóvel;

- **OUTROS ITENS NECESSÁRIOS/ESPECÍFICOS**
- Não foi possível verificar pendências financeiras junto ao INCRA;
- Há edificações dentro do lote que invadem a área de APP. Será necessária a demolição destas pois não são regularizáveis;
- Há edificações dentro do lote que precisarão ser regularizadas, para que posteriormente possamos fazer o desmembramento de áreas;
- Possivelmente teremos uma multa ambiental para este terreno, pois foram observadas intervenções ambientais no terreno ao longo dos anos;

Obrigado