Tenda

sua próxima conquista

Book de Investimento - **Comitê Essencial**

Regional: SP – Zona Oeste

Projeto: Terrazo Butantã (**Alfredo Xavier de Andrade)**

Data Comitê: 30/06/2025

Comitê Digital 26/06

Nome	Terrazo Butantã - Essencia	Observação - Terrazo Butantã
Alexandre Regis de Oliveira	Aprovado	n/a
Renan Barbosa Sanches	Aprovado	ok
Alejandro Octavio Abiusi	Aprovado	ok
Amanda da Silva Bezerra	Aprovado	ok
Fabricio Quesiti Arrivabene	Aprovado	Ok
Rodrigo Osmo	Discutir em Comitê	(1) Por que acreditamos que conseguimos atingir uma renda superior a Cury e Vinx, e com VSO equivalente?
Andre Luis Menegazzo Padilha	Aprovado	ok
Luiz Mauricio de Garcia Paula	Aprovado	ok

(1) Por que acreditamos que conseguimos atingir uma renda superior a Cury e Vinx, e com VSO equivalente?

O Life Jaguaré (Tenda) sendo concorrente direto do empreendimento da Cury e sendo um produto básico da Tenda (zero atributos), já performa a renda estimada no parecer com volume de vendas maior que o projetado para o Terrazo – análise focada na renda superior nas unidades HMP. Independentemente disto, é relevante considerar e conforme descrito nos materiais que o Terrazo será provido de vários atributos – inclusive já com a simulação de piscina. Abaixo, apresentamos o gráfico com a performance do Life Jaguaré e a tabela comparativa entre os empreendimentos.

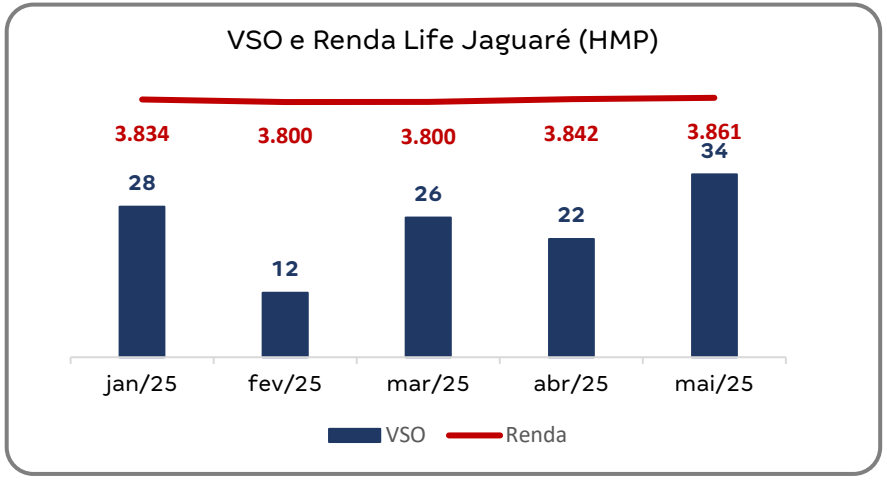

	Life Jaguaré HMP	Terrazo HMP
Renda	3.832	3.794
VSO Líquido	21	8

Estaremos assumindo um desafio ao trabalhar no mesmo patamar de renda que concorrência em apenas 8 vendas/mês dessa tipologia HMP s/ varanda (40% do VSO do projeto), e também ofereceremos um produto equivalente, com piscina, varanda e metragem similar. Isso nos permite praticar preços e rendas competitivas em relação ao mercado. Adicionalmente, visto que o projeto tem previsão de comitê ampliado no 2S25 e lançamento previsto para 1T27, poderemos ter stock-out da concorrência. Podemos também avaliar ganhos de atributo como 100% das uh com varanda, e se manter com o produto mais acessível para essa tipologia.

One Page – Alfredo Xavier de Andrade

Cidade	São Paulo	**Mancha de demanda**	SP - SZO1 - São Paulo Oeste 1
Regional	SP	**Cluster MPR**	4 - Azul
Cenário de Aprovação	Aprovação	**Tipo de Aprovação**	Consolidado
Fase Anterior	N/A		
Tipo de Comitê	Essencial	**Versão da VF**	Versão 1.0: Jun

Unidades (% Vagas)	353 (0%)	**CA Máx | Proj**	5,4 | 3,9
Tipologia	F2E - Concreto	**Escritura**	jan-27
Fases	1 fases	**Lçto | Duração (m)**	mar/27 | 26

Valor Líquido do Terreno (% VGV)	9.926 (10,1%)	**Un. Perm. Fís (% Ter)**	14 (37,5%)
Cash (Correção)	6.200 (IPCA)	**%VGV Perm Fin Líquida (% Ter)**	0,0% (0,0%)
Valor R$/m²	3.310	**VAR (%VGV)**	000 (0,0%)

Custo Construção (%VGV)	38.976 (39,5%)	**Indireto Unit.**	22.162
Prazo da Obra (meses)	19	**Torre Unit.**	58.446
Custo Total Unit. | Corrigido (LPU):	110.414 | 110.983 (89)	**Infra Unit.**	16.748
Início de Obra	set-27	**Fundação Unit.**	8.435

Preço Nominal Unit.	279.666	**VSO**	19
Preço Raso Unit.	258.847	**Referência**	Vision
Avaliação Unit.	283.116	**Renda (% em RET 1%)**	4.791 (0,0%)

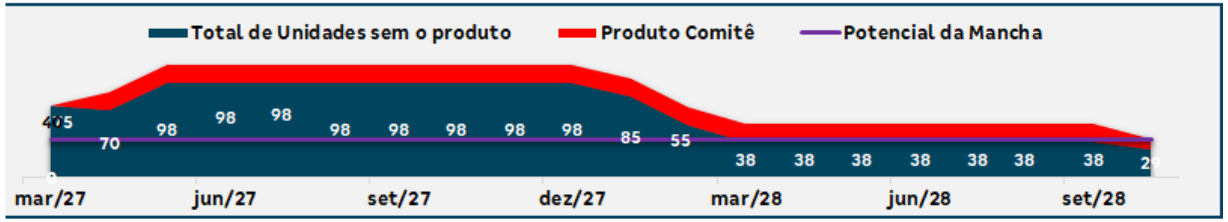

LI (Régua):	**20,0% (20,0%)**	**Margem Bruta Econômica:**	40,5%
LI Resiliência:	11,6% (N/A)	**Margem Rasa Econômica:**	35,4%
Margem Bruta REF:	43,9%	**Margem Contribuição Econômica:**	28,4%
Margem Rasa REF:	**39,4%**	**Exposição (% VGV):**	15.946 (14,8%)
TIR:	92,8%	**VGV Total:**	98.722
Payback Contingente (21 m) :	**20 m/ (-1 m)**	**Ger. Caixa 12 meses (R$):**	(300)
Payback Consolidado:	20	**Ger. Caixa 24 meses (R$):**	(5.712)

Destaques

[1] Terreno formado pela composição de 3 lotes de vendedores diferentes, com composição em dinheiro e permuta física, totalizando 3.011m2 (área de matricula); Localização estratégica e privilegiada no Butantã (Zona Oeste 2) entre as Av. Politécnica, Av. Corifeu de Azevedo Marques, Shopping Butantã e Rodovia Raposo Tavares.

[2] O projeto é composto por 1 condomínio com 353 unidades, sem vagas, fase única, com a tipologia T+17, 1 torre com 12PP e 1 torre com 8PP;
- Zoneamento ZC que limita o gabarito em T+17; CA do projeto está em 3,9x, sendo o CA máx 5,4x;
- O projeto contemplou a torre 12pp com 100% de varandas gerando no total um % um pouco superior a premissa na compra atingindo 58% de varandas – superior a premissa em 28 unidades;
- Pela localização diferenciada e tamanho do projeto, exploraremos todos os atributos possíveis para qualificação – simulação inicial de DPP no slide 9 já indica inclusive espaço para piscina.

[3] Valor total (soma dos 3 lotes) é de R$ 10.400.000,00 (valor reduzido na viabilidade pois a permuta física está precificada contratualmente com um valor superior de R$ 300K;
OBS: Aproximadamente R$ 847/CA e R$ 3.296/m2;
- 60% em dinheiro parcelado pós escritura e 40% em permuta física no local;
- As 14 permutas físicas foram definidas como sendo unidades sem varanda, e 9 unidades sendo HIS2 e 3 unidades R2V;
- Da parcela em dinheiro, ~65% é sem correção monetária;
- Garantia através de confissão de dívida e aval Tenda.

[4] Resolutivas principais:
a) Etapa I: Prazo 120 dias para resolutivas técnicas, jurídicas e financeira;
b) Etapa II: Em até 18 meses após a superação da Etapa I para aprovação de projeto, contratação CEF, análise técnica, financeira e comercial para o lançamento do empreendimento;
c) Critério da Tenda para suspender os contratos pelo prazo que for necessário, suspendo as obrigações de pagamento e lavratura da escritura;

[5] Projeto para aprovação no formato de Comitê Essencial, dentro da régua de 20% de LI e baixa de 70% das unidades; temos expectativa de trazermos para comitê Ampliado no 2S25.

Pareceres

Análise da Mancha e Implantação

Prospecção

Operações

Incorporação

Inteligência de Mercado

Financeiro

Anexos

Pareceres

Área	Riscos Associados	Parecer	Flag
Jurídico	**Lote 2** – Até o momento não foram localizados apontamentos relevantes que coloquem em risco a aquisiçãoConsiderando que a aquisição envolve três imóveis e que, conforme a due diligence preliminar, a soma dos passivos atribuídos tanto aos proprietários tabulares quanto aos futuros proprietários (herdeiros) representa montante inferior ao valor acordado para a aquisição, entende-se, até o momento, que não há elementos que configurem risco jurídico relevante à transação. Ressalta-se, contudo, a necessidade de acompanhamento da efetiva formalização da permuta entre o Sr. Manoel e os herdeiros do Sr. Antonio, conforme pactuado entre as partes **(Lote 6)**. Adicionalmente, para viabilizar a continuidade da aquisição, é imprescindível o inventário da proprietária tabular do **Lote 12**, bem como a emissão de certidões na Comarca do Estado do Pará, local de residência do Sr. Luciano.	Ok, com ressalvas	
Legalização	Possível contaminação	Ok	
DPP	Terreno apresenta topografia acentuada, necessário levantamento para entender possíveis ganhos e impactos no projeto	Ok com ressalvas	
Inteligência de mercado	IM avalia o preço vision como factível	Ok	
Estudos Econômicos	Ok, para o comitê essencial	Ok	
Prospecção	Negócio formatado a partir da unificação de 3 lotes com vendedores diferentes. Pagamento do terreno 100% após EVC. Os 3 CVCs mantém a clausula padrão que nos possibilita adiantar e descontar do preço 100% dos valores gastos com remediação, em caso de comprovação de contaminação ambiental. Produto com atributos de piscina e 58% das unidades com varandas. Considerado nível 4 para contenções na ferramenta estimativa de custo, de forma conservadora, até confirmação do projeto após elaboração de AP e parametrização.	Ok	
Ciclo Financeiro	O Ciclo avaliou o preço e o VSO como factíveis. O projeto está localizado em uma região estratégica e com grande potencial, e os concorrentes apresentam rendas similares ao Terraza, indicando oportunidade de um futuro lançamento com atributos, piscina e varanda	Ok	

Pareceres

Análise da Mancha e Implantação

Prospecção

Operações

Incorporação

Inteligência de Mercado

Financeiro

Anexos

Localização – Rua Alfredo Xavier de Andrade – Butantã – São Paulo - SP

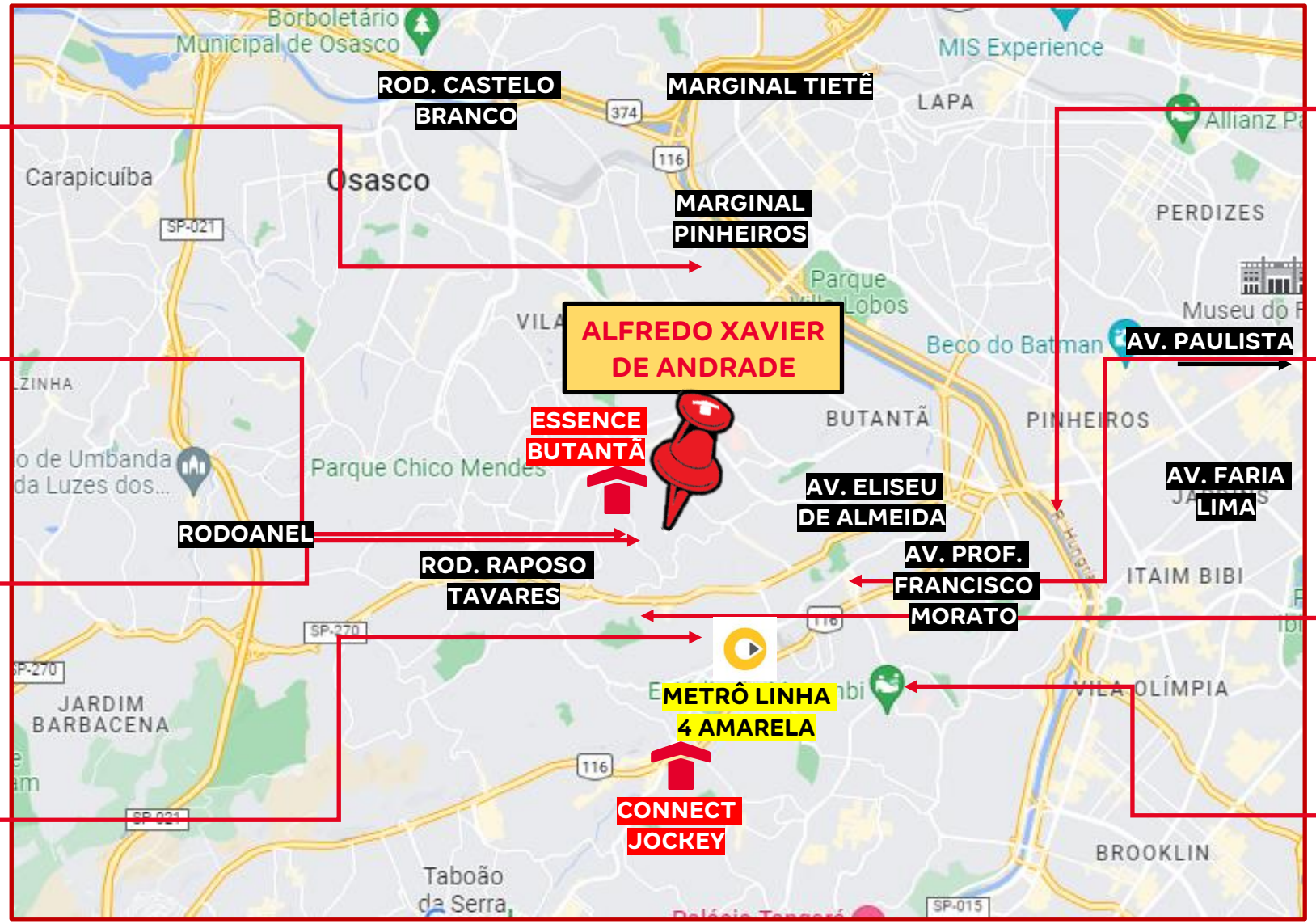

USP

ESCOLA CEU BUTANTÃ


PARQUE LINEAR YPUERA

METRÔ LINHA 4 AMARELA

SHOPPING ELDORADO

SHOPPING BUTANTA

SHOPPING RAPOSO

ESTÁDIO MORUMBIS

Localização – Rua Alfredo Xavier de Andrade – Butantã – São Paulo - SP

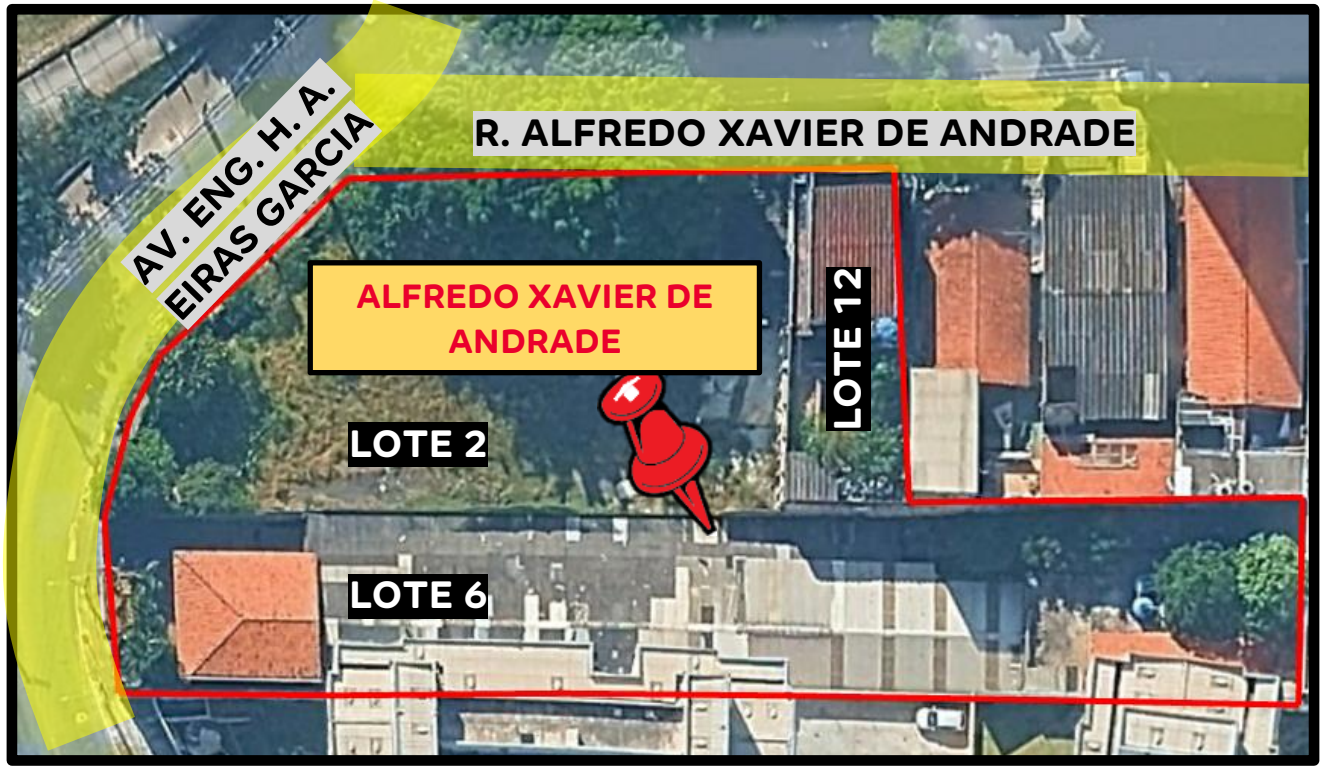

Mancha de Demanda

MANCHAS DE DEMANDA
• SZO– São Paulo Oeste

Lançamento

1. Life Jaguaré

LandBank

2. Connect Jockey
3. Villa Butantã
4. Essence Butantã (Eiras Garcia)
5. Terrazo Butantã

Cluster MPR – (Comitê)
● Cluster 4 - Azul

Região
Capital

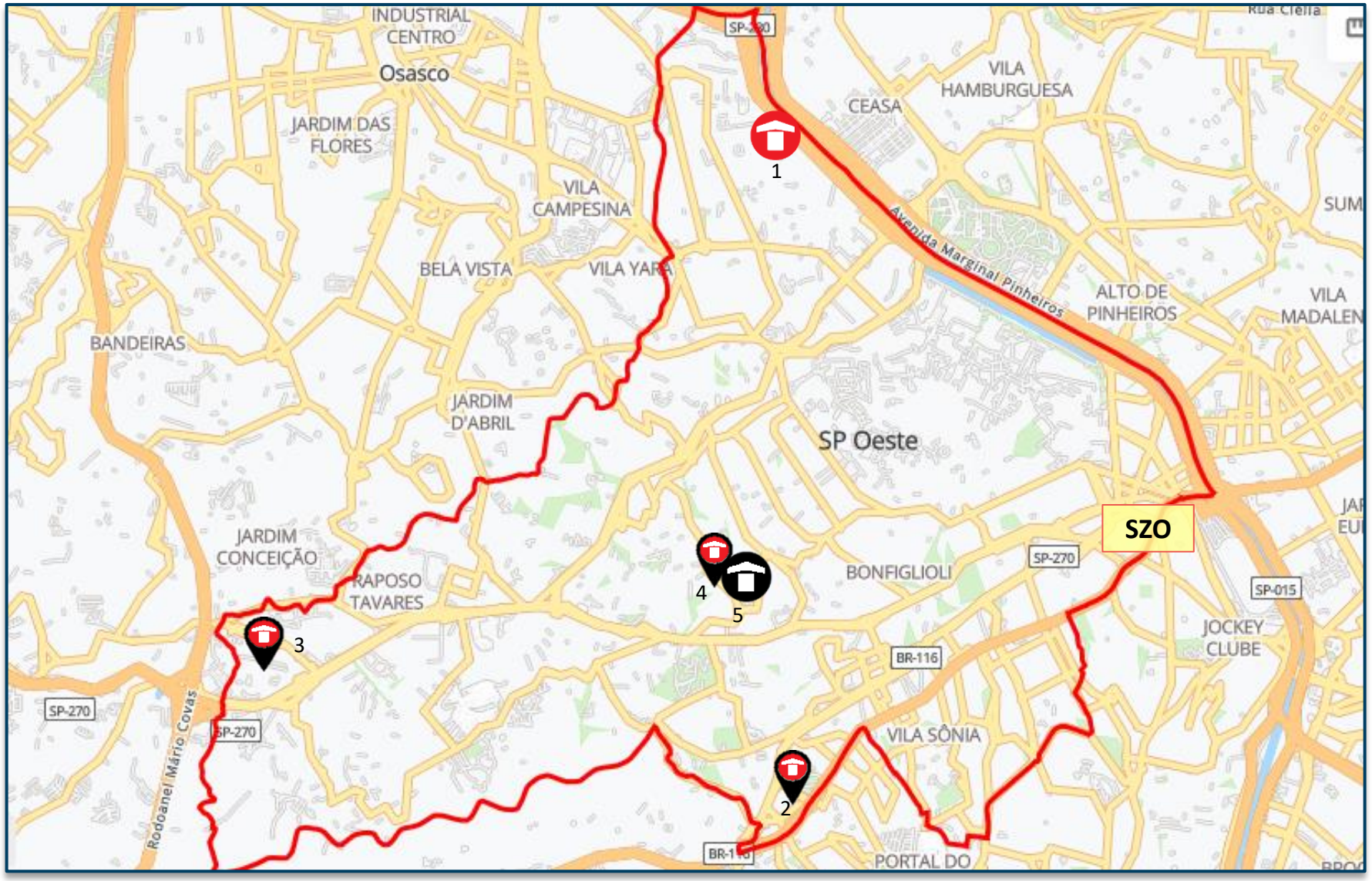

Lançados *LandBank* *Comitê*

PRODUTO

Alfredo Xavier de Andrade
Investimento

Informações Gerais – Condomínio Único			
Terreno	Área terreno	3.200,00m²	
	Menor poligonal	3.200,00m²	
	FNA/Reserva de calçada	200,95m²	
	Área liquida	2.999,05m²	
	Zoneamento	ZC	
	CA máximo	5,40	ZONA: 3,0
			COTA HIS: 0,30
			COTA R2V: 0,60
			INCENTIVO HIS1: 1,5
	CA projetado	3,89	
	Gabarito máximo	48m (T+17)	
Geral	Total UH	353	
	Total de vagas	2 (Embarque e PCD)	
Tipologia	Tipologia	V0200 12PP-NF-C V0200 08PP-LF-C	
	Gabarito	T+17	
	Lâmina	1x 20PP-NF-C 1x 8PP-LF-C	
	Área privativa	31,86m²	
Condomínio	Unidade PCD	11	
	Unidade lazer | técnica	05 | 02	
	Torre	02	
	Fase	Única	

RUA ALFREDO XAVIER DE ANDRADE

ESTUDO DE MASSAS

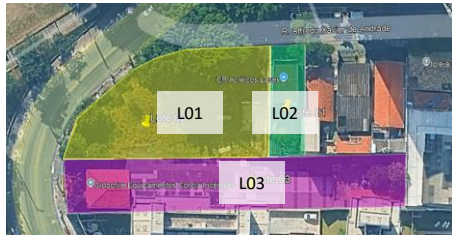

Planta chave

LEGENDA:

01 Piscina
02 Face com varanda
03 Reserva de calçada
04 Área Técnica

PRODUTO

Alfredo Xavier de Andrade Investimento

	Descrição	Criticidade	Parecer
Usabilidade	**Acesso Empreendimento**	🟢	
	Percurso do pedestre até torre	🟢	
Diferencial produto	**Prime**	Sim	
	Supercondomínio	Não	
	Atributos Infra	Sim	Piscina
	Atributos Torre	Sim	Varanda na torre 12PP (204 UH com varanda, representa 57%)
	Edifício Garagem	Não	

Demolição complexa para o remembramento de matrículas

	Considerações	Criticidade	Descrição
Material analisado	KMZ	🟢	
	Mapa Digital da Cidade 2004	🟡	Base desatualizada.
	Matrícula	🟢	
Projeto	Área líquida	🟢	
	Topografia	🟡	Terreno apresenta topografia complexa, com base topográfica usada para o estudo desatualizada, inclusive, divergente do real, podendo resultar em impactos na implantação.
	Drenagem	🟢	

HIS-2 SEM VARANDA	149	42%
HIS-2 COM VARANDA	95	27%
R2V COM VARANDA	109	31%
TOTAL DE UH	353	

Pareceres

Análise da Mancha e Implantação

Prospecção

Operações

Incorporação

Inteligência de Mercado

Financeiro

Anexos

Condições do Negócio

➢ VALOR DO NEGÓCIO / CONDIÇÃO COMERCIAL

- R$ 10.400.000,00 (Dez milhões e quatrocentos mil reais) – Aproximadamente R$ 847/CA e R$ 3.296/m2 e fração de 10,1%/VGV;
- Na viabilidade o custo do terreno está em R$ 9,926MM, pois a permuta física das unidades estão precificadas contratualmente com um valor superior ao previsto em VF);
- ~60% em dinheiro parcelado pós escritura e ~40% em permuta física no local.

➢ FORMA DE PAGAMENTO

- **Lote 2**: R$ 3.700.000,00 sendo: (i) R$ 2.200.000,00 em 6 parcelas mensais, consecutivas e corrigidas pelo IPCA (data base para início da correção data outorga da EVC), sendo a primeira parcela contra a outorga da EVC, e (ii) R$ 1.500.000,00 através de 160m² de área privativa, equivalente a 5 uh HIS-2 s/ varanda, em permuta física no local. Pagamento de ITBI e emolumentos referente às 5 uh permutadas, estimado em R$ 60.000,00, será de responsabilidade da Tenda. Valor foi previsto em VF somado ao custo de ITBI do terreno.
- **Lote 12:** R$ 1.500.000,00 através de 160m² de área privativa, equivalente a 5 apartamentos, sendo 3 uh HIS-2 s/ varanda e 2 uh R2V c/ varanda em permuta física no local. Pagamento de ITBI e emolumentos referente às 5 uh permutadas <u>será de responsabilidade dos Vendedores</u>.
- **Lote 6**: R$ 5.200.000,00, sendo: (i) R$ 4.000.000,00 em 12 parcelas mensais, consecutivas e fixas, sendo a primeira parcela contra a outorga da EVC e (ii) R$ 1.200.000,00 através de 128m² de área privativa, equivalente a 4 apartamentos HIS-2 s/ varanda em permuta física no local. Pagamento de ITBI e emolumentos referente às 4 uh permutadas <u>será de responsabilidade dos vendedores</u>.

➢ PRAZOS CONTRATUAIS

- Etapa I: CVCs tem prazo de 120 dias para resolutivas técnica, jurídica e financeira. Previsão pelo cronograma de legalização é de 180 dias (janeiro/26). Neste caso os 3 CVCs preveem possibilidade de suspensão de prazo à nosso critério, conforme clausula 6.2. Para nos adequar ao cronograma de legalização faremos suspensão dos prazos;
- Etapa II: CVC dos lotes 6 e 12 tem prazo de 18 meses após a superação da Etapa I, enquanto que CVC do lote 2 tem prazo de 12 meses após a superação da Etapa I, ambos para aprovação de projeto, contratação CEF, análise técnica, financeira e comercial para o lançamento do empreendimento. Para nos adequar ao cronograma de legalização faremos suspensão dos prazos;
- Previsão para outorga da EVC no cronograma de legalização é 20 meses (janeiro/27).
- Conforme cláusula 6.2 do CVC assinado podemos suspender os prazos contratuais mediante envio de comunicação por escrito em caso de não superação de qualquer condição resolutiva à critério da Tenda pelo prazo que for necessário, suspendo as obrigações de pagamento e lavratura da escritura;

Condições do Negócio

- PREVISÃO EM CONTRATO DE DESCONTOS DO PREÇO

- Ambiental: Em caso de necessidade Tenda pagará remediação e descontará 100% do preço. O desconto dos valores adiantados serão atualizados pelo IPCA até a efetiva compensação. Condição regrada em todos os lotes.

- GARANTIAS

- Confissão de dívida + Aval TNI. Condição regrada em todos os lotes.

- CORRETAGEM

- Pago pela Tenda no valor de R$ 624.000,00 (equivalente a 6%) em 6 parcelas mensais e corrigidas pelo IPCA (data base para início da correção superação da 1ª etapa de resolutivas, previsto para dez/25), pagas proporcionalmente a cada EVC.

Condições do Negócio

Pagamento Terreno Consolidado			
	Total Terreno	(6.200.000)	
	Sinal R$	-	
	Data Sinal	0	
	Prazo de carência (meses)	0	
	Nº Parcelas (unid)	0	
	Valor parcelas (R$)	-	
0	jun/25	-	Compra Terreno
1	jul/25	-	
2	ago/25	-	
3	set/25	-	
4	out/25	-	
5	nov/25	-	
6	dez/25	-	
7	jan/26	(300.000)	
8	fev/26	-	
9	mar/26	-	
10	abr/26	-	
11	mai/26	-	
12	jun/26	-	
13	jul/26	-	
14	ago/26	-	
15	set/26	-	
16	out/26	-	
17	nov/26	-	
18	dez/26	-	
19	jan/27	(400.000)	Escritura
20	fev/27	(700.000)	
21	mar/27	(700.000)	Lançamento
22	abr/27	(700.000)	
23	mai/27	(700.000)	
24	jun/27	(700.000)	
25	jul/27	(333.333)	
26	ago/27	(333.333)	
27	set/27	(333.333)	Início Obra
28	out/27	(333.333)	
29	nov/27	(333.333)	
30	dez/27	(333.333)	
31	jan/28	-	

Foi considerado em VF R$ 300.000,00 (0,30% do VGV) em formato de adiantamento para regularizações jurídicas do **lote 6**, após superação da 1ª etapa de resolutivas. Todo valor adiantado será atualizado pelo IPCA até a efetiva compensação, e contra AF em garantia para restituição em caso de desistência pela Tenda.

Condições do Negócio

➢ RESOLUTIVAS DO CONTRATO LOTE 2

I - Em até 120 (cento e vinte) dias a contar da assinatura do presente instrumento (previsão CVC outubro/25 + suspensão à critério da Tenda | previsão Leg janeiro/26 - faremos suspensão do CVC para adequação do prazo):

i. a existência de ação de desapropriação e/ou declaração de utilidade pública que objetive o Imóvel ou parte dele;
ii. a existência de cadastro como imóvel tombado e/ou em processo de tombamento e/ou em áreas envoltórias, no IPHAN, CONDEPHAAT ou CONPRESP, que impossibilitem a adequada consecução do Empreendimento;
iii. a não apresentação da documentação e/ou esclarecimentos indicados nas cláusulas 3.1, 3.2, 3.2.1 e 3.4 e no ANEXO I pelos VENDEDORES no prazo ali indicado ou a existência de qualquer apontamento nos documentos e certidões forenses que objetive, onere e/ou possa trazer vício à cadeia dominial do Imóvel e/ou possam reduzir os VENDEDORES ao estado de insolvência civil, ou que traga insegurança jurídica na operação objeto deste instrumento, a exclusivo critério da COMPRADORA;
iv. a impossibilidade da realização do estudo de passivo ambiental ou a existência de qualquer tipo de contaminação do solo, subsolo e águas do Imóvel, bem como qualquer outro tipo de passivo ambiental e/ou impossibilidade de remoção de árvores que comprometam o Empreendimento que a COMPRADORA pretende desenvolver no Imóvel;
v. a existência de óbice à consecução, no Imóvel, do Empreendimento imobiliário almejado pela COMPRADORA;
vi. a não viabilidade das redes de água e esgoto existentes no local, que sejam tidas como insuficientes a garantir a vazão necessária às unidades autônomas que comporão o Empreendimento pretendido;
vii. a não viabilidade de rede elétrica para abastecimento do futuro Empreendimento;
viii. o não aperfeiçoamento de uma ou mais condições resolutivas, relativas ao terreno e ao Empreendimento, abaixo relacionadas:
(a) Apuração de condições técnica e eventualmente impeditivas do Imóvel; e
(b) Análise jurídica da documentação do terreno e demais pessoas que serão analisadas, nos termos da cláusula 3.1, supra;
ix. caso o gabarito de altura pretendido para o Empreendimento pretendido não seja aprovado no DECEA (Departamento de Controle do Espaço Aéreo) e COMAER (Comando da Aeronáutica);
x. caso o presente negócio não seja aprovado pelo Comitê de Investimentos da COMPRADORA;
xi. caso seja constatada pela COMPRADORA a existência de terceiros ocupantes no Imóvel, existindo pessoas e coisas, que impeçam a transferência da posse para a COMPRADORA de forma inteiramente livre e desimpedida, nos termos previstos no presente instrumento;

Condições do Negócio

➢ RESOLUTIVAS DO CONTRATO LOTE 2

II – Em até 12 (doze) meses a contar da superação das condições descritas no item "I", supra (previsão CVC outubro/26 + suspensão à critério da Tenda/ previsão Leg janeiro/27 - faremos suspensão do CVC para adequação do prazo);

xii. a impossibilidade de a COMPRADORA adquirir de forma segura e definitiva os Imóveis Contíguos;

xiii. a inviabilidade de aprovação nos termos da legislação vigente do projeto do Empreendimento junto à Prefeitura Municipal e demais órgãos competentes, necessários para viabilizar sua edificação;

xiv. a inviabilidade de contratação de financiamento pela instituição financeira para construção do Empreendimento, consoante os termos e condições do Programa Minha Casa Minha Vida (MCMV), ou qualquer outro programa que venha a substituí-lo, inclusive por força da alteração do cenário jurídico constatado no âmbito da auditoria jurídica anteriormente realizada, a ser novamente verificado por meio da análise dos documentos e certidões em nome dos VENDEDORES e do Imóvel atualizados com 30 (trinta) dias de antecedência para a outorga da Escritura de Venda e Compra do Imóvel, nos termos da cláusula 3.5, supra;

xv. o não aperfeiçoamento de quaisquer das condições resolutivas, relativas ao terreno e ao Empreendimento, abaixo relacionadas:

(a) Análise da viabilidade técnica e financeira do Empreendimento;

(b) Análise da viabilidade comercial do Empreendimento;

(c) Verificação da manutenção da segurança jurídica, contemplando a análise das certidões dos VENDEDORES e do Imóvel;

Condições do Negócio

➢ RESOLUTIVAS DO CONTRATO LOTE 6

I - Em até 120 (cento e vinte) dias a contar da assinatura do presente instrumento (previsão CVC outubro/25 + suspensão à critério da Tenda | previsão Leg janeiro/26 - faremos suspensão do CVC para adequação do prazo):

i. a existência de ação de desapropriação e/ou declaração de utilidade pública que objetive o Imóvel ou parte dele;
ii. a existência de cadastro como imóvel tombado e/ou em processo de tombamento e/ou em áreas envoltórias, no IPHAN, CONDEPHAAT ou CONPRESP, que impossibilitem a adequada consecução do Empreendimento;
iii. a não apresentação da documentação e/ou esclarecimentos indicados nas cláusulas 3.1, 3.2, 3.2.1 e 3.4 e no ANEXO I pelos VENDEDORES no prazo ali indicado ou a existência de qualquer apontamento nos documentos e certidões forenses que objetive, onere e/ou possa trazer vício à cadeia dominial do Imóvel e/ou possam reduzir os VENDEDORES ao estado de insolvência civil, ou que traga insegurança jurídica na operação objeto deste instrumento, a exclusivo critério da COMPRADORA;
iv. a impossibilidade da realização do estudo de passivo ambiental ou a existência de qualquer tipo de contaminação do solo, subsolo e águas do Imóvel, bem como qualquer outro tipo de passivo ambiental e/ou impossibilidade de remoção de árvores que comprometam o Empreendimento que a COMPRADORA pretende desenvolver no Imóvel;
v. a existência de óbice à consecução, no Imóvel, do Empreendimento imobiliário almejado pela COMPRADORA;
vi. a não viabilidade das redes de água e esgoto existentes no local, que sejam tidas como insuficientes a garantir a vazão necessária às unidades autônomas que comporão o Empreendimento pretendido;
vii. a não viabilidade de rede elétrica para abastecimento do futuro Empreendimento;
viii. o não aperfeiçoamento de uma ou mais condições resolutivas, relativas ao terreno e ao Empreendimento, abaixo relacionadas:
(a) Apuração de condições técnica e eventualmente impeditivas do Imóvel; e
(b) Análise jurídica da documentação do terreno e demais pessoas que serão analisadas, nos termos da cláusula 3.1, supra;
ix. caso o gabarito de altura pretendido para o Empreendimento pretendido não seja aprovado no DECEA (Departamento de Controle do Espaço Aéreo) e COMAER (Comando da Aeronáutica);
x. caso o presente negócio não seja aprovado pelo Comitê de Investimentos da COMPRADORA;
xi. caso seja constatada pela COMPRADORA a existência de terceiros ocupantes no Imóvel, existindo pessoas e coisas, que impeçam a transferência da posse para a COMPRADORA de forma inteiramente livre e desimpedida, nos termos previstos no presente instrumento;
xii. caso não tenha sido realizada a Notificação do Inquilino sobre a venda do Imóvel com a obtenção da renúncia do direito de preferência.

Condições do Negócio

➢ RESOLUTIVAS DO CONTRATO LOTE 6

II – Em até 18 (dezoito) meses a contar da superação das condições descritas no item "I", supra (previsão CVC janeiro/27 + suspensão à critério da Tenda/ previsão Leg janeiro/27);

xiii. caso não tenha sido concluída a regularização dominial do Imóvel com a superação das condições essenciais dispostas nas alíneas "b" e "c" do item 1.6, o que restará comprovado por meio da apresentação da certidão de matrícula em nome dos respectivos VENDEDORES;
xiv. a impossibilidade de a COMPRADORA adquirir de forma segura e definitiva os Imóveis Contíguos;
xv. a inviabilidade de aprovação nos termos da legislação vigente do projeto do Empreendimento junto à Prefeitura Municipal e demais órgãos competentes, necessários para viabilizar sua edificação;
xvi. a inviabilidade de contratação de financiamento pela instituição financeira para construção do Empreendimento, consoante os termos e condições do Programa Minha Casa Minha Vida (MCMV), ou qualquer outro programa que venha a substituí-lo, inclusive por força da alteração do cenário jurídico constatado no âmbito da auditoria jurídica anteriormente realizada, a ser novamente verificado por meio da análise dos documentos e certidões em nome dos VENDEDORES e do Imóvel atualizados com 30 (trinta) dias de antecedência para a outorga da Escritura de Venda e Compra do Imóvel, nos termos da cláusula 3.5, supra;
xvii. o não aperfeiçoamento de quaisquer das condições resolutivas, relativas ao terreno e ao Empreendimento, abaixo relacionadas:
(a) Análise da viabilidade técnica e financeira do Empreendimento;
(b) Análise da viabilidade comercial do Empreendimento;
(c) Verificação da manutenção da segurança jurídica, contemplando a análise das certidões dos VENDEDORES e do Imóvel;
xviii. caso não tenha sido formalizado o "Distrato da Locação", com a superação das condições dispostas nos itens 1.5 e 1.5.1.

Condições do Negócio

➢ RESOLUTIVAS DO CONTRATO LOTE 12

I - Em até 120 (cento e vinte) dias a contar da assinatura do presente instrumento (previsão CVC outubro/25 + suspensão à critério da Tenda | previsão Leg janeiro/26 - faremos suspensão do CVC para adequação do prazo):

i. a existência de ação de desapropriação e/ou declaração de utilidade pública que objetive o Imóvel ou parte dele;
ii. a existência de cadastro como imóvel tombado e/ou em processo de tombamento e/ou em áreas envoltórias, no IPHAN, CONDEPHAAT ou CONPRESP, que impossibilitem a adequada consecução do Empreendimento;
iii. a não apresentação da documentação e/ou esclarecimentos indicados nas cláusulas 3.1, 3.2, 3.2.1 e 3.4 e no ANEXO I pelos VENDEDORES no prazo ali indicado ou a existência de qualquer apontamento nos documentos e certidões forenses que objetive, onere e/ou possa trazer vício à cadeia dominial do Imóvel e/ou possam reduzir os VENDEDORES ao estado de insolvência civil, ou que traga insegurança jurídica na operação objeto deste instrumento, a exclusivo critério da COMPRADORA;
iv. a impossibilidade da realização do estudo de passivo ambiental ou a existência de qualquer tipo de contaminação do solo, subsolo e águas do Imóvel, bem como qualquer outro tipo de passivo ambiental e/ou impossibilidade de remoção de árvores que comprometam o Empreendimento que a COMPRADORA pretende desenvolver no Imóvel;
v. a existência de óbice à consecução, no Imóvel, do Empreendimento imobiliário almejado pela COMPRADORA;
vi. a não viabilidade das redes de água e esgoto existentes no local, que sejam tidas como insuficientes a garantir a vazão necessária às unidades autônomas que comporão o Empreendimento pretendido;
vii. a não viabilidade de rede elétrica para abastecimento do futuro Empreendimento;
viii. o não aperfeiçoamento de uma ou mais condições resolutivas, relativas ao terreno e ao Empreendimento, abaixo relacionadas:
    (a) Apuração de condições técnica e eventualmente impeditivas do Imóvel; e
    (b) Análise jurídica da documentação do terreno e demais pessoas que serão analisadas, nos termos da cláusula 3.1, supra;
ix. caso o gabarito de altura pretendido para o Empreendimento pretendido não seja aprovado no DECEA (Departamento de Controle do Espaço Aéreo) e COMAER (Comando da Aeronáutica);
x. caso o presente negócio não seja aprovado pelo Comitê de Investimentos da COMPRADORA;
xi. caso seja constatada pela COMPRADORA a existência de terceiros ocupantes no Imóvel, existindo pessoas e coisas, que impeçam a transferência da posse para a COMPRADORA de forma inteiramente livre e desimpedida, nos termos previstos no presente instrumento;
xii. caso não tenha sido concluída a regularização dominial do Imóvel com a superação da condição essencial disposta na alínea “b” do item 1.5, o que restará comprovado por meio da apresentação da certidão de matrícula em nome os respectivos VENDEDORES.

Condições do Negócio

- RESOLUTIVAS DO CONTRATO LOTE 12

II – Em até 18 (dezoito) meses a contar da superação das condições descritas no item "I", supra (previsão CVC janeiro/27 + suspensão à critério da Tenda/ previsão Leg janeiro/27);

xiii. a impossibilidade de a COMPRADORA adquirir de forma segura e definitiva os Imóveis Contíguos;
xiv. a inviabilidade de aprovação nos termos da legislação vigente do projeto do Empreendimento junto à Prefeitura Municipal e demais órgãos competentes, necessários para viabilizar sua edificação;
xv. a inviabilidade de contratação de financiamento pela instituição financeira para construção do Empreendimento, consoante os termos e condições do Programa Minha Casa Minha Vida (MCMV), ou qualquer outro programa que venha a substituí-lo, inclusive por força da alteração do cenário jurídico constatado no âmbito da auditoria jurídica anteriormente realizada, a ser novamente verificado por meio da análise dos documentos e certidões em nome dos VENDEDORES e do Imóvel atualizados com 30 (trinta) dias de antecedência para a outorga da Escritura de Venda e Compra do Imóvel, nos termos da cláusula 3.5, supra;
xvi. o não aperfeiçoamento de quaisquer das condições resolutivas, relativas ao terreno e ao Empreendimento, abaixo relacionadas:
(a) Análise da viabilidade técnica e financeira do Empreendimento;
(b) Análise da viabilidade comercial do Empreendimento;
(c) Verificação da manutenção da segurança jurídica, contemplando a análise das certidões dos VENDEDORES e do Imóvel;

Pareceres

Análise da Mancha e Implantação

Prospecção

Operações

Incorporação

Inteligência de Mercado

Financeiro

Anexos

Custo de Construção – SIMULADOR

Alfredo Xavier de Andrade

ESTIMATIVA

DADOS DA OBRA		BASES		PRAZOS DE OBRA	
Regional:	SP	Data:	junho-25	Pré Forma:	6,4 meses
Endereço:		Revisão:	R00	Estrutura:	3,7 meses
Total de UH:	**360**	LPU:	LPU 89	Pós Forma:	9,0 meses
Total Torres:	2	LVS:	março-25	**TOTAL:**	**20,0 meses**
Produtos:	F2E Modular	INCC:	1.178,386		
Tipologia:	MODULAR 10PP/16PP T+15			Jogos de Formas:	2
				Takt:	2+2

CUSTOS DE CONSTRUÇÃO

	CUSTO	R$ / UND
CUSTO TOTAL I	**R$ 39.057.382**	**R$ 109.712**
INDIRETO	R$ 7.985.564	R$ 22.431
TORRE	R$ 20.806.648	R$ 58.446
INFRA	R$ 5.695.594	R$ 15.999
FUNDAÇÃO	R$ 3.002.705	R$ 8.435
ETE	R$ 0	R$ 0
EEE	R$ 0	R$ 0
CONTENÇÃO	R$ 1.264.698	R$ 3.553
TERRAPLENAGEM	R$ 302.173	R$ 849
CUSTO TOTAL II	**R$ 249.940**	**R$ 702**
VIÁRIO	R$ 149.940	R$ 421
DRENAGEM	R$ 0	R$ 0
EXTENSÃO ELÉTRICA	R$ 100.000	R$ 281
EXTENSÃO HIDRÁULICA	R$ 0	R$ 0
CUSTO TOTAL I + II	**R$ 39.307.322**	**R$ 110.414**
CUSTO TOTAL III	**R$ 0**	**R$ 0**
INCORRIDOS NÃO APROVEITADOS	R$ 0	R$ 0
CUSTO TOTAL I A III	**R$ 39.307.322**	**R$ 110.414**
CUSTO TOTAL I A IV	**R$ 39.307.322**	**R$ 110.414**

OBSERVAÇÕES GERAIS		RATEIO FASEAMENTO	
Parâmetro terraplenagem:	Nível 2	**% de Varanda:**	57%
Parâmetro Contenção:	Nível 4	**Possui Piscina:**	Sim

CRITÉRIOS DE INPUT DO SIMULADOR

- Previsto água e esgoto em frente ao empreendimento conforme diretriz emitida para o projeto "Essence Butantã", situado na quadra lindeira;
- **Considerado cenário conservador para as contenções do projeto**, com nível 4 (maior nível) na ferramenta estimativa de custo. Após realização dos estudos técnicos, elaboração de AP e parametrização, obteremos a confirmação.

Pareceres

Análise da Mancha e Implantação

Prospecção

Operações

Incorporação

Inteligência de Mercado

Financeiro

Anexos

Demanda e Distribuição da Mancha

Potencial de Demanda			Lançados		Lançados + Landbank	
Mancha	CÓD.	Shr.	ANO	MÊS	ANO	MÊS
São Paulo Oeste	SZO	52%	398	33	477	40

Empreendimento	Renda	Lançamento	mar/27	abr/27	mai/27	jun/27	jul/27	ago/27	set/27	out/27	nov/27	dez/27	jan/28	fev/28	mar/28	abr/28	mai/28	jun/28	jul/28	ago/28	set/28	out/28	nov/28	dez/28
Life Jaguaré F1	3.800	set-24	15																					
Farol Jaguaré I - F2	3.817	mar-27		10	38	38	38	38	38	38	38	38	38	38	38	38	38	38	38	38	38	29		
Villa Butantã	3.241	jul-26	40	40	40	40	40	40	40	40	40	40	27											
Essence Butantã	3.843	ago-26	20	20	20	20	20	20	20	20	20	20	20	17										
Terrazo Butantã	**4.791**	**mar-27**		**19**	**19**	**19**	**19**	**19**	**19**	**19**	**19**	**19**	**19**	**19**	**19**	**19**	**19**	**19**	**19**	**19**	**19**	**11**		
Total de Vendas Lançados			**15**	**0**	**0**	**0**	**0**	**0**	**0**	**0**	**0**	**0**	**0**	**0**	**0**	**0**	**0**	**0**	**0**	**0**	**0**	**0**	**0**	**0**
Total de Vendas Lançados + Landbank			**75**	**89**	**117**	**117**	**117**	**117**	**117**	**117**	**117**	**117**	**104**	**74**	**57**	**57**	**57**	**57**	**57**	**57**	**57**	**40**	**0**	**0**

Apesar de o total de unidades previsto para a mancha ser maior que o potencial de demanda calculado por I.M, não devemos ter problemas com VSO, pois os projetos, Villa Butantã e Farol Jaguaré estão na divisa com outras manchas e devem capturar vendas dessas regiões.

Parecer de I.M sobre a mancha:

O projeto analisado em comitê está acima do potencial teórico de demanda calculado para a mancha. (Total Lanç + Landbank)

Canibalização:

Sem Risco de Canibalização

Terrazo Butantã | Mapa Concorrência

		Terrazo Butantã	Cidade Jaguaré - Villa Lobos	Vinx Joaquim Seabra	Topic Jaguaré
		TENDA	Cury	Vinx	Econ
	Distância Tenda (km)		4,65Km	1,01Km	3,04Km
Região 1 Km	População	43.658	27.160	46.447	33.291
	Dens. Demográfica	13.986	8.701	14.880	10.665
	Renda (R$)	10.199	10.603	8.640	11.473
	Classe Social	B1 (8.1k a 16k)	B1 (8.1k a 16k)	B1 (8.1k a 16k)	B1 (8.1k a 16k)
	PEA Dia	27.163	27.848	29.681	43.290
Quantitativo	Lançamento	mar/27	04/2023	03/2025	10/2022
	Unidades	353	627	393	381
	Estoque	353	6	343	19
	VSO	19	24	17	11
	Stockout	19	0	21	2
Qualitativo	Condomínios	1	1	1	1
	Torres	-	4	2	3
	Gabarito	T+17	T+9	T+9	T+9
	Plantas (m²)	32,03m² | 33m²	43m² e 35m² e 35m²	25,9m² e 30,7m² e 33,5m² e 33,5m² e 47,81m²	45m² e 37m²
	Tipologia	2 Dorms	1 e 2 Dorms	1 e 2 Dorms	2 Dorms
	Opções	Não	Não	Garden	Não
	Varanda	Sim	Sim	Sim	Sim
	Suite	Não	Sim	Sim	Sim
	Dif. Entrega	Não	-	-	-
	Vagas	Sem vaga	Com vaga	Com vaga	Com vaga
	Lazer	Piscina, churrasqueira, salão de festas, brinquedoteca, espaço office, espaço fitness, espaço saúde, espaço teen, praça de convívio, firness externo, playpet e bicicletário,	Tem Sacada, Bicicletário, Campo de Futebol, Cinema, Lago, Lounge, Piscina, Piscina Aquecida, Piso Elevado, Praça, Quadra de Tênis, Sala de Reuniões / Treinamentos, Salão de Jogos,	Tem Sacada, Tem Garden, Agua Aquecida a Gas, Bosque, Campo de Futebol, Cinema, Climatização, Decorado, Fireplace, Lago, Lareira a Álcool, Lounge, Mercado, Pet Place, Piscina, Piscina Aquecida, Praça, Sacada, Sala de Reuniões / Treinamentos, Salão de Jogos, Sauna Seca, SPA,	Tem Sacada, Agua Aquecida a Gas, Campo de Futebol, Cinema, Decorado, Espaço Gourmet, Lago, Piscina, Piscina Aquecida, Piso Elevado, Praça, Quadra de Tênis, Sala de Reuniões / Treinamentos, Salão de Jogos, Sauna Seca,

Diagnóstico Concorrência

- O empreendimento da Econ vende em um target de preço e renda acima do estimado no parecer.
- Os demais empreendimentos (Vinx e Cury) vem apresentando uma performance de renda próxima ao que foi projetado para o Vision. No entanto, o produto da Tenda oferece atributos similares, como piscina e varanda, o que nos permite praticar um preço competitivo em relação ao mercado.

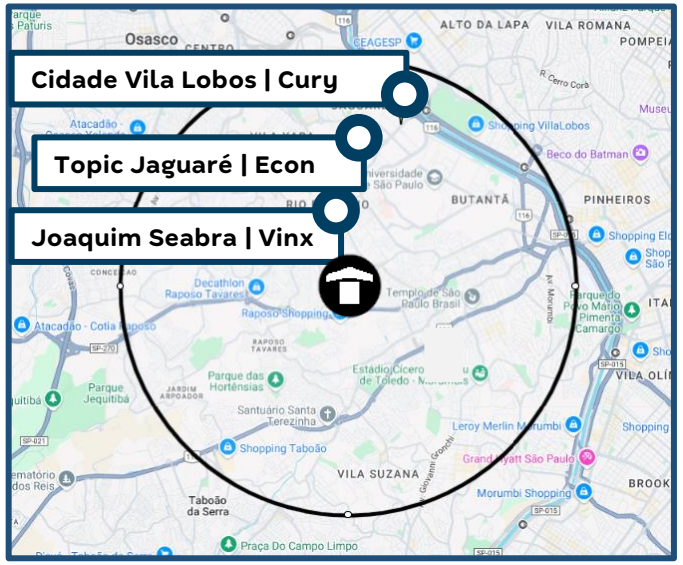

Tipologias	Empreendimento	Terrazo Butantã			Cidade Jaguaré - Villa Lobos			Vinx Joaquim Seabra			Topic Jaguaré		
	Tipologia	HMP	HMP - VARANDA	R2V - VARANDA	HMP	HMP - VAGA	HMP VAGA | VARANDA	HIS - COM VARANDA	HMP - COM VARANDA	R2V - COM VARANDA | COM VAGA	HMP - VARANDA	HMP - VARANDA E VAGA	R2V - VARANDA E VAGA
	Preço Nominal	260.203	284.812	301.788	253.302	313.040	323.518	270.900	282.100	376.700	303.993	362.960	374.600
	CEF	207.271	227.247	240.577	202.642	250.432	258.814	216.720	225.680	301.360	243.194	290.368	299.680
	Renda	3.794	5.359	5.659	3.598	6.098	6.248	4.500	5.300	7.290	5.848	6.998	7.198
	% Unidades	42%	42%	15%	-	-	-	-	-	-	-	-	-
	Dif Renda				-196	-	-	-859	-59	-	489	-	-
	Farol de Factibilidade				●	-	-	●	●	-	●	-	-

Farol Renda
● Acima de 300
● Entre 0 e 300
● Abaixo de 0

Simulação de Preço

Informações Viabilidade

Projeto:	Terrazo Butantã					
Tipo:	**HMP**		**HMP - VARANDA**		**R2V - VARANDA**	
Método	**Vision**		**Vision**		**Vision**	
Avaliação	260.000		300.000		300.000	
Renda Inicial (VF)	3.794		5.359		5.659	
Renda Final*	-		-		-	
% RET1	0%		0%		0%	
Tipo:	**VF**	**R$**	**VF**	**R$**	**VF**	**R$**
Ato	0,91	3.651	0,74	4.216	0,78	4.657
FGTS	0,96	3.873	0,74	4.199	0,77	4.632
Financiamento	96,92%	199.650	97,89%	223.048	97,73%	235.945
Subsídio	161,80%	3.749	0,00%	0	0,00%	0
Prazo de Pró-soluto	25	25	25	25	25	25
Pró-Soluto	80,74%	27.825	67,78%	32.993	70,42%	36.198
Preço Raso (RS)	238.748	238.748	264.456	264.456	281.432	281.432
TCD	56,10%	21.455	37,68%	20.356	35,69%	20.356
VSO	8	8	5	5	6	6
Preço de Venda	**245.217**	**245.217**	**268.409**	**268.409**	**284.408**	**284.408**
Elasticidade	6,111%	6,111%	6,111%	6,111%	6,111%	6,111%
Preço de Venda Final	**260.203**	**260.203**	**284.812**	**284.812**	**301.788**	**301.788**
Preço Raso (R$)	**238.748**		**264.456**		**281.432**	
% de Raso	**91,75%**		**92,85%**		**93,25%**	

A simulação de IM para unidades HMP equivale as unidades HIS-2 prevista na viabilidade

Análise de Preço

Informações Viabilidade

Projeto:	Terrazo Butantã
Tipo:	**Faixa 2**
Método	**Vision**
Avaliação	283.116
Renda Inicial (VF)	4.791
Renda Final*	-

Tipo:	VF	R$
Ato	0,82	4.114
FGTS	0,84	4.195
Financiamento	97,43%	217.154
Subsídio	68,30%	1.582
Prazo de Pró-soluto	25	25
Pró-Soluto	74,07%	31.801
Preço Raso (RS)	258.847	258.847
TCD	44,84%	20.820
VSO	19	19
Preço de Venda	**262.576**	**262.576**
Elasticidade	6,111%	6,111%
Preço de Venda Final	**279.666**	**279.666**

Preço Raso (R$)	**258.847**
% de Raso	**92,56%**

1

Análise de Riscos	Farol IM
IM avalia o Preço Vision como **factível**.	

1. I.M está de acordo com o preço Vision, tendo em vista que, o projeto está em uma região com bons indicadores sociodemográficos, como renda e PEA/Dia, o mesmo também se encontra próximo de pontos de interesses como hospital, escola e etc. Além disso, contará com incremento da piscina.

   Conforme consta no slide "Panorama de Concorrência", os empreendimentos da Vinx e Cury vem apresentando uma performance de renda próxima ao que foi projetado pelo Vision. No entanto, o produto da Tenda oferece atributos similares, como piscina e varanda, o que nos permite praticar um preço competitivo em relação ao mercado.

   Abaixo, segue o escalonamento da regional:

	Preço Real					Preço Normalizado (25m)	
	Avaliação	Preço Raso	Renda Média	VSO	PSOL	Δ PSOL	Preço Raso
Life Jaguaré	**237.265**	**209.509**	**3.821**	**26**	**18**	**7.994**	**217.503**
Terrazo Butantã	**283.116**	**258.847**	**4.791**	**19**	**25**	**-**	**258.847**

Ciclo Financeiro – Análise Mancha

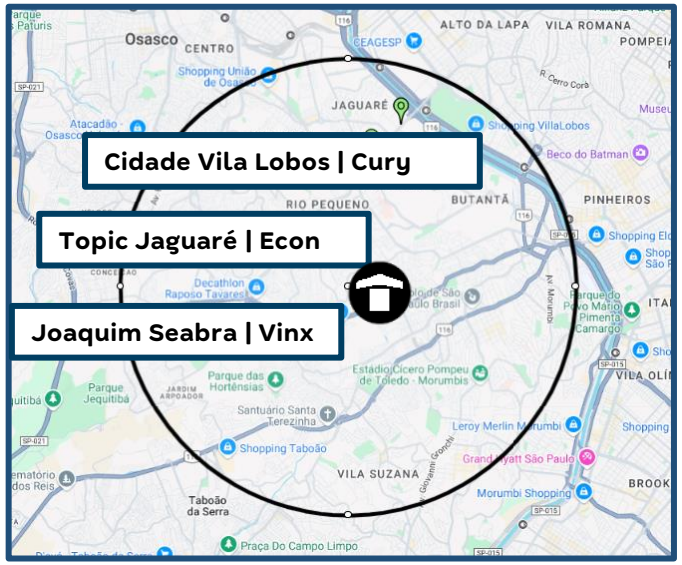

Parecer Ciclo

O Ciclo avaliou o preço e o VSO como factíveis. O projeto está localizado em uma região estratégica e com grande potencial, e os concorrentes apresentam rendas similares ao Terraza, indicando oportunidade de um futuro lançamento com atributos, piscina e varanda.

Pareceres

Análise da Mancha e Implantação

Prospecção

Operações

Incorporação

Inteligência de Mercado

Financeiro

Anexos

Resumo

Terrazo Butantã - SP - São Paulo Capital

Datas e Prazos

	Compra	Lançamento	Início Obra	Término Obra	LÇTO até IO	IO até TO	Chaves	LÇTO até Chaves
Consolidado	jun-25							
azo Butantã HIS-2 S/ VARANDA		mar-27	set-27	mai-29	6 meses	20 meses	mar-30	36 meses
ızo Butantã HIS-2 C/ VARANDA		mar-27	set-27	mai-29	6 meses	20 meses	mar-30	36 meses
razo Butantã R2V C/ VARANDA		mar-27	set-27	mai-29	6 meses	20 meses	mar-30	36 meses

Terreno e Incorridos

TOTAL (R$ + Perm.):	9,93 MM	Incorrido Terreno: 0,00 MM	Área do Terreno (100%):	3.011 m²	Área Líquida do Terreno: 2.999 m²
Cash:	6,20 MM		Custo de terreno m²:	3.296,6	Custo de terreno m² Área Líquida: 3.309,7
Permuta Financeira:	0,00 MM (0,00%)		VaR 25 (R$ mil):	0	Fração Terreno/Terreno + Custo Obra (%VGV): 10,1% / 49,5%
Permuta Física:	3,73 MM (3,77%) - Unidades Permuta 14,00		VaR 26 (R$ mil):	300	CA Máx/Proj. 5,4 / 3,9
Ato / %VGV:	0,00 MM / 0,0%		Incorrido de Construção:	0,00 MM	Incorridos de Incorporação: 0,00 MM

Vendas

Fases	Nº Pavimentos	Preço Raso Unit.	Qtde	Preço Unit.	Aval. CEF	Cond. Parcela	% Pró-soluto	% TCD
azo Butantã HIS-2 S/ VARANDA	T+17	238.748	149	260.203	260.000	96,9%	80,7%	56,1%
ızo Butantã HIS-2 C/ VARANDA	T+17	264.456	95	284.812	300.000	97,9%	67,8%	37,7%
razo Butantã R2V C/ VARANDA	T+17	281.432	109	301.788	300.000	97,7%	70,4%	35,7%

Unidades Totais:	353	Preço Médio:	279.666	Renda Média:	4.791	ITBI+Emol. Unit. Médio:	8.425
Unidades Tenda:	339	Avaliação Média:	283.116	Ato:	3.937 (0,82 Salários)	Custo do Ciclo Unit.:	17.605
VSO:	#REF!	VGV Total:	98.722.261	FGTS:	4.039 (0,84 Salários)	Preço Raso Médio:	258.847
RET Médio:	4,0%	VGV Tenda:	94.806.930	% em RET 1%:	0%	Adc. Tx. de Aceleração Médio:	750

Construção

Custo Total Unit. | Corrigido:	110.414 | 110.983	Eventuais:	4,00%	Área priv (m²):	33,00	Gape / Mês Unit.:	11,08

Resultado

LI (R$):	11.718.087	LI:	20,01%	Exposição de Caixa (R$):	15.945.662	Margem Bruta Econômica:	40,55%
TIR:	92,77%	LI Aprovação:	20,00%	Ger. Caixa 12 meses (R$):	(300.000)	Margem Bruta REF:	43,92%
Exposição de Caixa:	14,84%	Δ LI:	0,01%	Ger. Caixa 24 meses (R$):	(5.711.595)	Margem Rasa Econômica:	35,44%
Payback Contingente (21 m):	20 m/ (-1 m)	LI Resiliência:	11,59%	Ger. Caixa Marginal (R$):	28.003.143	Margem Rasa REF:	39,42%
Payback Consolidado:	20 meses					Margem de Contribuição Econômica:	28,39%

DRE

R$ Mil - Valores Nominais - Compra	Terrazo Butantã		Terrazo Butantã HIS-2 S/ VARANDA		Terrazo Butantã HIS-2 C/ VARANDA		Terrazo Butantã R2V C/ VARANDA	
	Nominal	%	Nominal	%	Nominal	%	Nominal	%
Receita	107.418	100,0%	42.552	100,0%	29.237	100,0%	35.630	100,0%
PIS/COFINS	(2.258)	2,1%	(851)	2,0%	(641)	2,2%	(766)	2,1%
Custo Total	(62.518)	59,5%	(28.245)	67,7%	(15.617)	54,6%	(18.657)	53,5%
Custo Terreno	(11.010)	10,5%	(6.514)	15,6%	(1.755)	6,1%	(2.740)	7,9%
Custo Relacionados a Terreno	(1.179)	1,1%	(498)	1,2%	(317)	1,1%	(364)	1,0%
Custos de Incorporação	(2.250)	2,1%	(939)	2,3%	(605)	2,1%	(706)	2,0%
Custo de Construção	(48.080)	45,7%	(20.294)	48,7%	(12.939)	45,2%	(14.846)	42,6%
Lucro Bruto Econômico	42.642	40,5%	13.456	32,3%	12.978	45,4%	16.208	46,5%
Custo para Rateio	-	0,0%	-	0,0%	-	0,0%	-	0,0%
Lucro Bruto Contábil	42.642	40,5%	13.456	32,3%	12.978	45,4%	16.208	46,5%
Despesas de Selling	(10.321)	9,8%	(3.867)	9,3%	(2.943)	10,3%	(3.511)	10,1%
Contingência	(2.471)	2,3%	(979)	2,3%	(672)	2,4%	(819)	2,4%
Margem de Contribuição	29.850	28,4%	8.610	20,6%	9.363	32,7%	11.877	34,1%
IR e CSLL	(1.847)	1,7%	(696)	1,6%	(525)	1,8%	(626)	1,8%
Margem Líquida	28.003	26,6%	7.914	19,0%	8.839	30,9%	11.250	32,3%
Lucro Bruto REF Unit.	137.182	43,9%	102.974	35,4%	156.573	49,0%	168.287	49,8%
Lucro Raso REF Unit.	113.902	39,4%	79.000	29,6%	133.775	45,1%	145.535	46,2%

R$ Mil - VPL - Compra	Terrazo Butantã		Terrazo Butantã HIS-2 S/ VARANDA		Terrazo Butantã HIS-2 C/ VARANDA		Terrazo Butantã R2V C/ VARANDA	
	VP	%	VP	%	VP	%	VP	%
Receitas	58.559	100,0%	23.246	100,0%	15.851	100,0%	19.462	100,0%
PIS/COFINS	(1.213)	2,1%	(458)	2,0%	(343)	2,2%	(412)	2,1%
Custos e Despesas Totais	(45.628)	77,9%	(19.902)	85,6%	(11.729)	74,0%	(13.998)	71,9%
Custo Terreno	(7.062)	12,1%	(3.990)	17,2%	(1.248)	7,9%	(1.824)	9,4%
Custo Relacionados a Terreno	(846)	1,4%	(357)	1,5%	(228)	1,4%	(261)	1,3%
Custos de Incorporação	(1.454)	2,5%	(607)	2,6%	(390)	2,5%	(457)	2,4%
Custo de Construção	(27.976)	47,8%	(11.808)	50,8%	(7.529)	47,5%	(8.638)	44,4%
Despesas de Selling	(6.595)	11,3%	(2.486)	10,7%	(1.863)	11,8%	(2.246)	11,5%
Contingência	(703)	1,2%	(279)	1,2%	(191)	1,2%	(233)	1,2%
IR e CSLL	(992)	1,7%	(375)	1,6%	(280)	1,8%	(337)	1,7%
Lucro Imobiliário	11.718	20,0%	2.886	12,4%	3.779	23,8%	5.053	26,0%

Pareceres

Análise da Mancha e Implantação

Prospecção

Operações

Incorporação

Inteligência de Mercado

Financeiro

Anexos

AMBIENTAL + LEGALIZAÇÃO – Paramétrico de custos

Tenda

REGIONAL SP

PARAMÉTRICO DE CUSTOS LEGALIZAÇÃO

DADOS		QUANDO APLICAR
Quantidade de unidades	353	
O Empreendimento terá R2V?	SIM	
Qual a área do Terreno?	3.011	
Quanto % do terreno Possui árvore?	20%	Se possivel contas arvores, considerar 6m² X quantidade de arvores / area do terreno. Caso não seja possivel, estimar por poligonal
Possível Área Contaminada?	NÃO	Terrenos com histórico de uso industrial anterior; Os vizinhos do entorno podem possuem uso geradores de contaminantes (posto de gasolina, fabricas, gasodutos, etc...);
Esta Cadastrado como Área Possivelmente Contaminada nos Orgão Publicos?	NÃO	Quando no GEOSAMPA estiver classificado como área possivelmente contaminada
Parcelamento do Solo?	NÃO	
Quantos Condomínios?	1	Incluir a quantidade de condomínios que serão gerados no licenciamento

ABERTURA	$ FINAL		MÉTRICA
Compensação Ambiental	R$	166.330	média histórica/ m² de terreno + acrescimo de 30% do valor com aplicação de R2V
Laudos, EIV, EIARIMA	R$	15.000	15k fixo
Emolumentos e Taxas	R$	5.000	5k - Revalidação de Certidões + 30k aprovação CETESB (contaminação) quando for classificado como potencialmente contaminado ou existir a possibilidade de ter contaminação;
Assessorias	R$	5.000	Custas second opinion Ambiental
Cópias, Plotagens, Autenticações, etc...	R$	15.000	15k fixo
Contra Partida	R$	-	Não temos contrapartida para SP Capital Considerado custas de contaminação/ remediação histórica dos empreendimentos em LB/ m² de terreno
Projeto de criação e Legal	R$	10.500	1.5k/condomínio de tercerização PL + 4k/condomínio de NBR + 5k complemento plani + 15k para parcelamento do solo (quando houver) + 3.5k para pl grapro (quando houver)
Total	**R$**	**216.830**	**R$ 614/uh**

CRITÉRIOS DE INPUT DO SIMULADOR

- Considerado 20% da área do terreno com árvores a serem suprimidas (terreno e calçada), mesmo que visualmente a área de implantação não tenha esse volume;
- Projeto sem desmembramento
- Projeto sem doação de área verde ou institucional;
- Empreendimento EHIS com unidades R2V;
- Previsto uma verba de R$350k para demolição;
- Não foi prevista verba para remediação, entretanto, está previsto em CVC que, em caso de confirmação de contaminação poderemos adiantar e descontar 100% do custo com remediação do preço do terreno;

JURÍDICO – Paramétrico de custos

Tenda

REGIONAL SP

PARAMÉTRICO DE CUSTOS JURÍDICO IMOBILIÁRIO

DADOS		QUANDO APLICAR
Quantidade Unidades	353	
Área Construída	14.032 m²	
Tem SQL?	SIM	
Valor do carne de IPTU	R$ 65.134	Considerar sempre o valor do caner de IPTU do ano de aplicação
Área de Matrícula	3.011	
Retificação?	SIM	Quando a matrícula não tiver o encerramento descrito e/ou detalhamento dos perímetro; Quando houver necessária de de acrescimo ou exclusão de áreas do real para implantação do empreendimento;
Quantos Condomínios?	1	
Quantos Proprietários de terreno?	16	
Parcelamento do Solo?	NÃO	C/ Doação: Quando matrícula tiver mais de 20.000m² ou for necessário abertura de mais lotes
Remembramento de Matrículas?	SIM	Quando a composição do empreendimento é composta por 2 ou mais matrículas para incorporar;
Com qual valor o terreno será escriturado?	R$ 10.400.000	

ABERTURA	$ FINAL	MÉTRICA
Desdobro de IPTU	R$ 2.500	R$ 2.5k/ condomínio
Instituição de Condomínio	R$ 441.250	R$ 1250/uh
Averbação da Construção	R$ 106.080	Área Construída(m²) X 4 meses de Cobrança X Índice Histórico (atual 1,79/m²)
Procuração Societária	R$ 5.000	5k fixo
IPTU (Anual)	R$ 65.134	Valor do caner vigente de IPTU ou em caso de não tenha IPTU, considerado para calculo área da matrícula X Índice Histórico (atual 1,79/m²)
Registro de Incorporação	R$ 174.130	R$ 210/uh + 40k quando houver necessidade de retificação
Honorário Incorporação	R$ -	Não gastamos mais com honorários de incorporação Considerado IPTU Retroativo por não ter SQL: $ IPTU X 5 anos
Cópias e Autenticações	R$ 15.000	15k fixo
Honorário Aquisição	R$ 120.000	120k - 2 ou mais prorietários do terreno 80k - 1 proprietário do terreno
Registro de Escritura	R$ 78.000	Valor do terreno X 0,75%
ITBI Terreno	R$ 312.000	Valor do terreno X 3%
Total	**R$ 1.319.094**	**R$ 3.737/uh**

CRONOGRAMA PRÉVIO

MÊS	RESP	ETAPA	INÍCIO	FIM	STATUS/ PRAZO (dias)	0	1	2	3	4	5	6	7	8	9	10	11	12	13	14	15	16	17	18	19	20
0	**PROSP**	**COMITÊ INVESTIMENTO ESSENCIAL**	**13/7/25**	**13/7/25**	**-**																					
	NEG	REUNIÃO PASSAGEM/ PARTIDA	20/7/25	20/7/25	-																					
	NEG	PLANIALTIMÉTRICO	25/7/25	29/8/25	35																					
	JRI	MATERIAL UNIFICAÇÃO + RETIFICAÇÃO	3/9/25	2/11/25	60																					
	JRI	RETIFICAÇÃO E UNIFICAÇÃO DE MATRICULA	2/11/25	30/6/26	240																					
	NEG	DIRETRIZ SABESP	4/8/25	18/9/25	45																					
	PRÉ-LEG	INVESTIGAÇÃO AMBIENTAL	30/7/25	27/11/25	120																					
	DPP	ELABORAÇÃO AP	18/9/25	8/10/25	20																					
	CUSTOS	PARAMETRIZAÇÃO	23/10/25	12/11/25	20																					
	NEG	CONFIRMAÇÃO FINANCEIRA	17/11/25	27/11/25	10																					
6	**NEG**	**COMITÊ INVESTIMENTO AMPLIADO**	**16/1/26**	**16/1/26**	**-**																					
	GETEC	ENGENHARIA SIMULTÂNEA	27/11/25	11/1/26	45																					
	GETEC	ELABORAÇÃO PROJETO SABESP	15/10/25	12/2/26	120																					
	GETEC	APROVAÇÃO SABESP	19/2/26	19/6/26	120																					
	GETEC	EP KIT LEGAL	12/1/26	18/5/26	126																					
	PL	ELABORAÇÃO PL	18/10/25	2/12/25	45																					
	LEG	CETESB (CONTAMINADO)	12/12/25	10/6/26	180																					
	LEG	ALVARÁ DE APROVAÇÃO E EXECUÇÃO	9/12/25	9/12/26	365																					
	LEG	DISPENSA DE GRAPROHAB	10/10/26	30/10/26	20																					
	NEG	**COMITÊ DE ESCRITURA/ LANÇAMENTO**	**16/12/26**	**16/12/26**	-																					
	JRI	ESCRITURA	29/12/26	28/1/27	30																					
	JRI	REGISTRO INCORPORAÇÃO	29/1/27	28/2/27	30																					
	CRD	LAUDOS CEF	10/12/26	10/3/27	90																					
20	**NEG**	**LANÇAMENTO**	**10/3/27**	**10/3/27**	**-**																					

- **DESCRIÇÃO DOS IMÓVEIS:**

  - **Lote 02: Matrícula nº 16.497** do 18º CRI de São Paulo/SP, localizado na Rua Alfredo Xavier de Andrade, nº 111, São Paulo/SP - Cadastro Municipal nº 159.177.0002-7**;**
  - **Lote 06: Matrícula nº 57.364** do 18º CRI de Imóveis de São Paulo/SP, localizado na Rua Eng. Heitor Antonio Eiras Garcia, nº 1727, São Paulo/SP - Cadastro Municipal nº 159.177.0006-1; e
  - **Lote 12: Matrícula nº 25.471** do 18º CRI de Registro de Imóveis de São Paulo/SP, localizado na Rua Alfredo Xavier de Andrade, nº 205, São Paulo/SP - Cadastro Municipal nº 159.177.0012-4.

- **PROPRIETÁRIOS TABULARES:**

  - **Lote 02:** ***(i)*** **Sueli Gatto**, ***(ii)*** **Silvio Antonio Gatto**, ***(iii)*** **Sergio Gatto**, e **(iv) Sinesio Jose Gatto**, cada um deles na condição de titular da parte ideal de 1/4 do imóvel – TITULARIDADE REGULARIZADA em nome do proprietários.

  - **Lote 06:** ***(i)*** **Espólio de Antonio Ramos Silva**, na condição de titular de ½ do imóvel, representado pela totalidade de seus herdeiros filhos: ***(i.i)*** **Rui Ramos Rodriguez**, ***(i.ii)*** **Fabiana Ramos Naufal**, e ***(i.iii)*** **Cynthia Gracioli Ramos** - estão pendentes documentos para validação da informação e identificação precisa da fração ideal correspondente a cada herdeiro, e **(ii) Manuel Otero Braco** na condição de titular de ½ do imóvel (em razão de ajustes havidos entre as partes, Manuel comparecerá no contrato como anuente, sendo que finalizado o inventário de Antonio Ramos, as partes farão a permuta da metade ideal pertencente ao anuente. TITULARIDADE IRREGULAR, sendo que a regularização depende do processamento e registro do inventários dos bens deixados por Antonio Ramos Silva, e formalização e registro da permuta da metade ideal do imóvel com o anuente Manuel Otero.

  - **Lote 12:** ***(i)*** **Espólio de Carmen Viana Inoue**, representado pela totalidade de seus herdeiros: ***(i.i)*** **Luciano Tokutika Viana Inoue**, na condição de titular da metade ideal do imóvel e de titular dos direitos hereditários sobre a parte ideal de 1/8 do imóvel; ***(i.ii)*** **Fernando Jose Takeshi Viana Inoue**, na condição de titular dos direitos hereditários sobre a parte ideal de 1/8 do imóvel; ***(i.iii)*** **Ricardo Hideo Viana Inoue**, na condição de titular dos direitos hereditários sobre a parte ideal de 1/8 do imóvel; e ***(i.iii)*** **Patricia Aparecida Viana Inoue Castanho**, na condição de titular dos direitos hereditários sobre a parte ideal de 1/8 do imóvel. TITULARIDADE IRREGULAR sendo que a regularização depende do processamento e registro do inventários dos bens deixados por Carmem Viana Inoue.

- **CONSIDERAÇÕES JURÍDICAS SOBRE OS IMÓVEIS:**

  - **(a) Retificação:** Será analisado em estudos técnicos, inclusive sobre o aspecto de unificação dos 3 lotes; **(b) Loteamento:** Providenciaremos as certidões do imóvel até a origem (transcrição) para verificarmos se o imóvel atual foi objeto de loteamento no passado e em caso positivo verificaremos eventuais restrições; **(c) Desmembramento:** considerando a área total do terreno após a unificação, não será necessário providenciar o desmembramento, uma vez que será um único empreendimento; **(d) Área construída:** *(d.1)* **Lote 2:** a matrícula menciona a construção de um prédio com a área de 76m², área esta que condiz com a certidão de dados cadastrais da PMSP; *(d.2)* **Lote 6:** não há menção de construção na matrícula, no entanto perante a PMSP há uma construção de 879m²; *(d.3)* **Lote 12:** a matrícula menciona apenas a construção de uma casa sem menção da área construída, já a certidão de dados cadastrais menciona uma área construída de 320m², caso seja necessário seguir com as regularizações das áreas construídas para demolição, no momento oportuno, seguiremos com as providencias necessárias; **(f) Multas, CONDEPHAAT, CONPRESP, IPHAN, Desapropriação e Melhoramentos:** Serão apurados em Due Diligence; **(g) Ônus e Gravames**: Com base nas certidões emitidas até o presente momento, não há apontamento de ônus e gravames; **(h) Ocupação**: Os imóveis encontram-se ocupados da seguinte forma: *(h.1)* **Lote 2:** pelos proprietários; *(h.2)* **Lote 6:** imóvel é objeto de contrato de locação não residencial celebrado pelo prazo de 60 meses, com início em 01/01/2021 e término em 31/12/2025; e *(h.3)* **Lote 12:** pelos proprietários; **(i) Função Social da Propriedade:** Considerando que há um contrato de locação vigente e o uso pelos proprietários a função social da propriedade está sendo exercida, nos termos da Constituição Federal.

- **CONSIDERAÇÕES PRELIMINARES SOBRE OS PROPRIETÁRIOS:**

- **Do Lote 02:** ***(i)*** **Em nome de Ivone Bonet de Roig Gatto:** CND da RFB não emitida, pendente recebimento do extrato fiscal para esclarecimentos da não emissão da referida certidão, **5 apontamentos** no TJSP, relacionados a débitos de IPTU de imóveis divergentes; ***(ii)*** **Em nome de Silvo Antonio Gato: 1 apontamento** no TJSP, relacionado a Conversão de Separação Judicial em Divórcio; ***(iii)*** **Sinesio Jose Gatto: 1 apontamento** no TJSP, relacionado a Conversão de Separação Judicial em Divórcio; ***(iv)*** **Tatiane Martins Tribst: 1 apontamento** no TJSP, relacionado a Execução Fiscal e Licença e Funcionamento, com valor histórico de R$ 1.898,74; Conversão de Separação Judicial em Divórcio.

- **Do Lote 06:** ***(i)*** **Em nome de Antonio Ramos Silva:** constam * **2 apontamentos** na certidão estadual cível com qualificação confirmada, referentes a execuções fiscais movidas pela Prefeitura do Município de São Paulo, sendo: **(a)** processo nº 0507178-42.2015.8.26.0090, ação de execução fiscal (IPTU), valor histórico de R$ 3.455,68; e **(b)** processo nº 1552040-37.2022.8.26.0090, ação de execução fiscal (IPTU), valor histórico de R$ 14.806,00, ambos de imóveis divergentes. Considerando que o nome Antonio Ramos Silva é um nome muito comum, a emissão das certidões em seu nome resultou na identificação dos processos listados abaixo. No entanto, diante das datas envolvidas e da ausência de elementos identificadores diretos, será necessário solicitar o desarquivamento dos autos para verificação, a fim de confirmar tais demandas efetivamente referem-se ao proprietário do lote em questão. * **1 apontamento** na certidão estadual criminal, por crime de roubo e extorsão (processo nº 0008561-32.1977.8.26.0224), e 1 apontamento referente a crime de receptação (processo nº 0000004-67.1967.8.26.0269), além de distribuição cível conexa (processo nº 0000004-96.1969.8.26.0269), todos com origem confirmada. Consta também certidão positiva criminal no TRF da 3ª Região, com três ações penais, sendo: **(a)** processo nº 0013167-02.2008.4.03.6106, situação: sobrestado/homônimo; **(b)** processo nº 0100015-74.1994.4.03.6108, arquivado; e **(c)** processo nº 0817782-11.1984.4.03.6181, findo.

- Constam, por fim, **52 processos adicionais relacionados ao nome Antonio Ramos Silva, sem identificação de CPF ou RG**, os quais **podem referir-se a homônimos e considerando que não foi iniciado, até o momento, processo de inventário e partilha de bens pelos herdeiros, entende-se, em uma análise preliminar, que não há elementos suficientes para afirmar que tais demandas estejam vinculados ao Antonio**. Dentre os principais tipos de ações identificados, destacam-se: inventários e partilhas em diversas comarcas (ex: Itaquera, Santana, São Miguel Paulista, Piracaia, Atibaia, Várzea Paulista); separações consensuais e conversões de separação em divórcio (ex: Diadema, Tatuí, Penha de França); usucapiões, execuções fiscais (IPTU e fornecimento de água), alvarás judiciais, e procedimentos comuns cíveis (ex: ação de anulação, embargos à execução e execuções de título extrajudicial), distribuídos em comarcas como Américo Brasiliense, Cotia, Peruíbe, Cerqueira César, São Paulo (capital e regionais), Guarulhos, Hortolândia, Sumaré, entre outras;

- ***(ii)*** **Em nome de Fabiana Ramos Naufal:** certidão da PGE do Estado de São Paulo positiva, pendente apresentação de extrato fiscal; **3 apontamentos** na certidão estadual cível, sendo: **(a)** processo nº 0012403-71.2000.8.26.0011, referente à ação de reintegração de posse ajuizada por Bcsp Leasing S.A., com valor histórico de R$ 12.500,00; **(b)** processo nº 1007119-80.2024.8.26.0704, ação monitória ajuizada por Banco Bradesco S.A., valor histórico de R$ 114.667,46; e **(c)** processo nº 1007189-97.2024.8.26.0704, ação de cobrança relativa a cartão de crédito, com valor histórico de R$ 113.543,73;

- ***(iii)*** **Em nome de Manoel Otero Barco: 2 apontamentos** na certidão estadual cível, sendo: **(a)** processo nº 0000656-59.2018.8.26.0152, ação de cumprimento de sentença com fundamento em fraude à execução, valor histórico de R$ 86.416,19; e **(b)** processo nº 0462942-54.1992.8.26.0011, embargos de terceiro cível envolvendo posse, ajuizado por Matrix Indústria de Moldes e Plásticos Ltda., distribuído em 04/12/1992, com tramitação física.

- **Do Lote 12:** ***(i)*** **Em nome de Luciano Takutika Viana Inoue: 1 apontamento** na Justiça Federal – TRF da 3ª Região, relacionado à execução fiscal movida pela União Federal (processo nº 5022570-84.2019.4.03.6182), em trâmite na 4ª Vara de Execuções Fiscais de São Paulo, atualmente sobrestado; **3 apontamentos** no TJSP, todos relacionados a execuções fiscais ajuizadas pela Prefeitura Municipal de Marília por débitos de ISS, com valores históricos de R$ 7.265,04, R$ 9.280,84 e R$ 7.466,82;

- ***(ii)*** **Em nome de Patrícia Aparecida Viana Inoue Castanho**: CND da Receita Federal emitida com efeito de negativa, constando débitos tributários com exigibilidade suspensa nos termos do art. 151 do CTN; consta ainda certidão positiva de débitos mobiliários relacionados ao endereço Rua Estados Unidos, nº 1059 – CEP: 01427-002, pendente apresentação de extrato fiscal; ***(iii)*** **Em nome de Ricardo Hideo Viana Inoue: 2 apontamentos** no TJSP, sendo um relacionado a cumprimento de sentença de obrigação de prestar alimentos (processo nº 0125524-57.2007.8.26.0003) e outro relativo a separação consensual (processo nº 0012278-98.2003.8.26.0011).

- **CONCLUSÃO.: Lote 2 –** Até o momento não foram localizados apontamentos relevantes que coloquem em risco a aquisição**. Lote 6 -**Cogita-se a possibilidade de homonímia do Sr. Antonio. Desta forma, estamos em fase de confirmação quanto a qualificação dele como requerido nas certidões emitidas.
  Verifica-se a pendência de regularização da titularidade do imóvel, em razão do falecimento do Sr. Antonio, bem como da necessidade de formalização da transferência dos 50% atualmente pertencentes ao Sr. Manoel. Referida fração ideal será objeto de permuta entre as partes, mediante ajuste celebrado com os herdeiros do Sr. Antonio, em razão da copropriedade de outro imóvel. Considerando essa permuta, eventuais valores devidos em decorrência de processos em nome do Sr. Manoel não comprometem a aquisição, uma vez que o imóvel objeto de troca possui valor superior ao montante da dívida, assegurando, assim, a cobertura da obrigação.
  Em relação ao **Lote 12**, recomenda-se, no âmbito da Due Diligence, considerar a possível existência de união estável constituída pelo herdeiro Luciano Takutika Viana Inoue no Estado do Pará, uma vez que o mesmo apresentou documentação judicial e declarou domicílio naquele estado, bem como a necessidade de inventário judicial, considerando o falecimento de uma das tabulares. Considerando que a aquisição envolve três imóveis e que, conforme a due diligence preliminar, a soma dos passivos atribuídos tanto aos proprietários tabulares quanto aos futuros proprietários (herdeiros) representa montante inferior ao valor acordado para a aquisição, entende-se, até o momento, que não há elementos que configurem risco jurídico relevante à transação. Ressalta-se, contudo, a necessidade de acompanhamento da efetiva formalização da permuta entre o Sr. Manoel e os herdeiros do Sr. Antonio, conforme pactuado entre as partes. Adicionalmente, para viabilizar a continuidade da aquisição, é imprescindível o inventário da proprietária tabular do **Lote 12**, bem como a emissão de certidões na Comarca do Estado do Pará, local de residência do Sr. Luciano, obtido ciência da residência do Luciano apenas em 17/06/2025, logo não tivemos tempo hábil para emitir as certidões neste local de residência.

LEGALIZAÇÃO E DPP

➢ ÁREA DE IMPLANTAÇÃO

- O terreno é composto por 3 matrículas, todas do 18º CRI, em nome de pessoas físicas, que totalizam uma área escriturária de 3.011,00m²;
- O cadastro do imóvel é urbano;
- O cenário foi desenvolvido sobre a poligonal do MDC definida 2.999,05m²;
- Largura de via, conforme Ficha Técnica:
    - Rua Alfredo Xavier de Andrade – 12,80m
    - Avenida Engenheiro Heitor Antônio Eiras Garcia – 14,60m

➢ DIRETRIZES URBANÍSTICAS

- O terreno esta inserido em ZC, conforme decreto 63.728/2024:
    - C.A. máximo: 3 para EHIS, 2,5 para EHMP, com restrição de gabarito de 48,00m, TO 70% e PA 5. É necessária a reserva de calçada.
- Terreno não será parcelado em condomínios em função do numero de unidades habitacionais;
- O estudo considera implantação de 1 condomínio, prevendo 02 cenários. Sendo eles:
    - CEN1: 1 torre 8PP T+17 e 1 torre 12PP T+17, com 353 UH, sendo 81UH incentivo HIS-1 – CA 3,89
    - CEN2: 1 torre 18PP em L, T+17, com 321UH, sendo 49UH incentivo HIS-1 – CA 3,54
- Em função do zoneamento, não é exigido cota parte;
- A legislação não exige vaga de garagem, cenário não considera vagas;
- Usos permitidos: EHIS e EHMP.

➢ GRAPROHAB

- Numero de UH do estudo (EM) é menor que 800 UH, sendo passível de **dispensa**;

LEGALIZAÇÃO E DPP

➢ AVALIAÇÕES AMBIENTAIS

Arbóreo

- Conforme consulta ao GeoSampa, o terreno **não** é considerado como Patrimônio Ambiental. Porém, na Ficha Técnica temos que é um patrimônio Ambiental em decorrência da existência de uma espécie arbórea na quadra onde está localizado o terreno. Necessário Laudo Arbóreo para confirmação se está no terreno.
- Não incide sobre o terreno APP;
- Necessário laudo arbóreo para confirmação de existência de fragmento;
- Não foi enviada parametrização para validação.
- A propriedade não está inserida em Área de Patrimônio Ambiental (APA), Área de Proteção de Mananciais (APRM) e Unidade de Conservação;
- Cenário considera a supressão de todos os exemplares localizados no interior do lote e mais 03 localizados na calçada da Rua Alfredo Xavier de Andrade.
- Compensação de 1:10 (HIS e HMP), para cenário R2v seguir legislação;

Hidrografia

- O Imóvel não apresenta corpos d'água internos ao perímetro, porém consta um na Av. Engº Heitor Antônio Eiras Garcia, canalizado;
- Córrego mais próximo é o Córrego da Água Podre, que passa em frente ao terreno e tem um lago há cerca de 80m do imóvel;

➢ AVALIAÇÕES AMBIENTAIS

Contaminação (Contaminado)

1- Conforme consulta ao GeoGegran o terreno não é objeto de contaminação;
2 – Conforme Ficha Técnica, o imóvel é cadastrado perante a municipalidade;

Para efeito de comitê essencial foi considerado o terreno como **contaminado**, devido aos usos pretéritos e atuais dos terrenos.

LEGALIZAÇÃO E DPP

- **ÓRGÃOS DE PATRIMÔNIO HISTÓRICO**
- De acordo com a certidão CIT, o imóvel é isento de aprovação perante ao CONPRESP, CONDEPHAAT, UPPH e DPH;
- **DRENAGEM**
- Lançamento da drenagem será visto em AP;

- **URBANIZAÇÃO**
- Não consta DUP/DIS ou ação visando a desapropriação do imóvel, bem como o mesmo não é atingido por plano de melhoramento viário ou sanitários;
- Conforme croqui patrimonial, não consta área pública no imóvel;

- **OUTROS ITENS NECESSÁRIOS/ESPECÍFICOS**
- Observado pendencia financeira na consulta preliminar no site da Prefeitura para o imóvel de SQL 159.177.0012-4 ;
- Há edificação a ser demolida no terreno. Necessária regularização de matrículas;

Obrigado