Tenda

sua próxima conquista

Comitê de escritura e lançamento

Regional: SP

Projeto: Alvorada Aricanduva (Sobral)

Data Comitê: 05/09/2025

Comitê Digital 01/09/2025 – Alvorada Aricanduva

Nome	Alvorada Aricanduva - Escritura + Lançamento	Observação - Alvorada Aricanduva
Fabricio Quesiti Arrivabene	Aprovado	Ok
Alejandro Octavio Abiusi	Aprovado	Ok
Alexandre Regis de Oliveira	Aprovado	Ok
Luiz Mauricio de Garcia Paula	Aprovado	uma implantação em U seria viável?
Renan Barbosa Sanches	Aprovado	Ok
Amanda da Silva Bezerra	Aprovado	Ok
Rodrigo Osmo	Discutir em comitê	1.Essa mecânica de % de permuta, mas com valor em R$ garantido (quitado x meses pós início da obra) parece uma artimanha bem engenhosa para estar na mente de todas as regionais, uma vez que estamos com perspectiva de ganho de unidades em vários terrenos. Isso evita termos que rediscutir a permuta em caso de ganho de unidades, quando invariavelmente teríamos que ceder parte do ganho para o terreneiro. 2. Projeto vizinho do Viva Parque do Carmo. Por que acreditamos que Parque do Carmo não sofreria com esse lançamento, uma vez que tem preço maior e PSOL muito menor?; 3. Vision sinaliza um preço R$8K maior do que o justificável pelo Parque do Carmo (projeto vizinho de muro); por que acreditaríamos nisso?

Luiz Mauricio: Uma implantação em U seria viável?

Resposta: À época do atendimento de comunique-se deste projeto, a torre em U não era uma opção disponível. De qualquer forma, fizemos um exercício rápido e chegamos ao total de 561uh, 16 a menos que o projeto atual. Isso porque o projeto atual tem 24pp no total, sendo uma torre T+23 e uma T+24, contra a torre em U com 22pp T+25. Na torre em U foi possível chegar em T+25 pois as pontas não são flex, enquanto nas torres laminares foi obrigatório manter as pontas flex para atingir os 24pps.

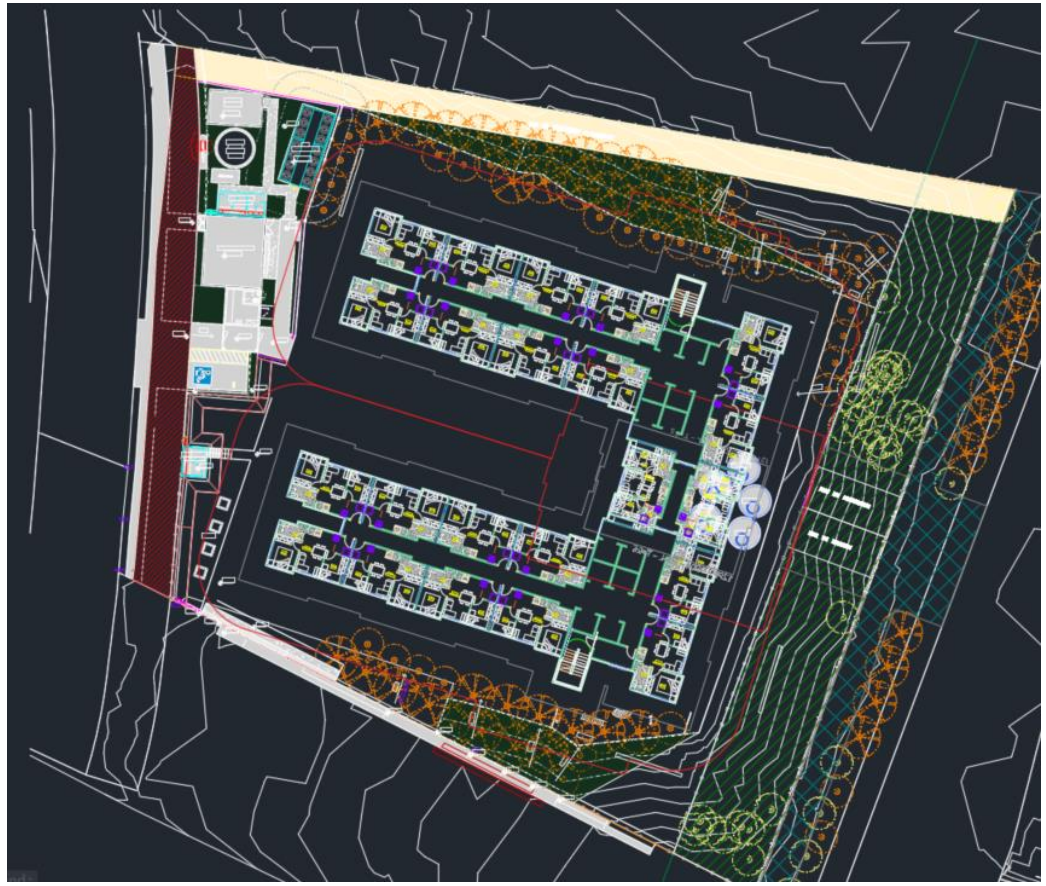

Osmo: 1. Essa mecânica de % de permuta, mas com valor em R$ garantido (quitado x meses pós início da obra) parece uma artimanha bem engenhosa para estar na mente de todas as regionais, uma vez que estamos com perspectiva de ganho de unidades em vários terrenos. Isso evita termos que rediscutir a permuta em caso de ganho de unidades, quando invariavelmente teríamos que ceder parte do ganho para o terreneiro. 2. Projeto vizinho do Viva Parque do Carmo. Por que acreditamos que Parque do Carmo não sofreria com esse lançamento, uma vez que tem preço maior e PSOL muito menor?

Resposta: 2. O Parque do Carmo não será impactado, pois não apresenta preço superior ao Alvorada. Os valores demonstrados por IM refletem a média dos últimos três meses, desconsiderando agosto. Ao incorporar o mês de agosto mantendo a média dos últimos 3 meses, o preço raso médio das unidades foi de R$ 214.610, e ao analisarmos o ano de 2025 registramos um raso médio de R$ 212.004 – todas unidades sem vaga. Embora o prazo de pró-soluto do Carmo seja menor (22 meses frente a 25 meses no Alvorada), o Parque do Carmo segue mais competitivo por estar com menor preço.

Embora estejam inseridos na mesma mancha, não são vizinhos diretos com distância de aproximadamente 1,8Km (em linha). Ainda assim, o Alvorada tem uma “localização micro” privilegiada por estar com melhor e mais curto acesso ao Shopping Aricanduva. Acreditamos que o Parque do Carmo se posicionará como reversão do Alvorada Aricanduva. Vale destacar ainda que o Carmo lançou 709 unidades em agosto/2024 e hoje conta com apenas 248 disponíveis, sendo 222uh sem vaga.

Resposta Comitê

Osmo: 3. Vision sinaliza um preço R$8K maior do que o justificável pelo Parque do Carmo (projeto vizinho de muro); por que acreditaríamos nisso?

Resposta: 3. Apesar da proximidade entre o Alvorada Aricanduva e o Viva Parque do Carmo, o Alvorada apresenta localização superior conforme detalhado no slide anterior. O mapa de calor abaixo demonstra os polos de atratividade, áreas que concentram mais comércios (shopping, lojas, restaurantes, farmácias etc.), com isso podemos verificar que o raio de influência do Alvorada concentra maior atratividade em comparação ao Viva Parque do Carmo, o que naturalmente atrai mais pessoas. Além disso, o Alvorada obteve uma avaliação superior ao Parque do Carmo.

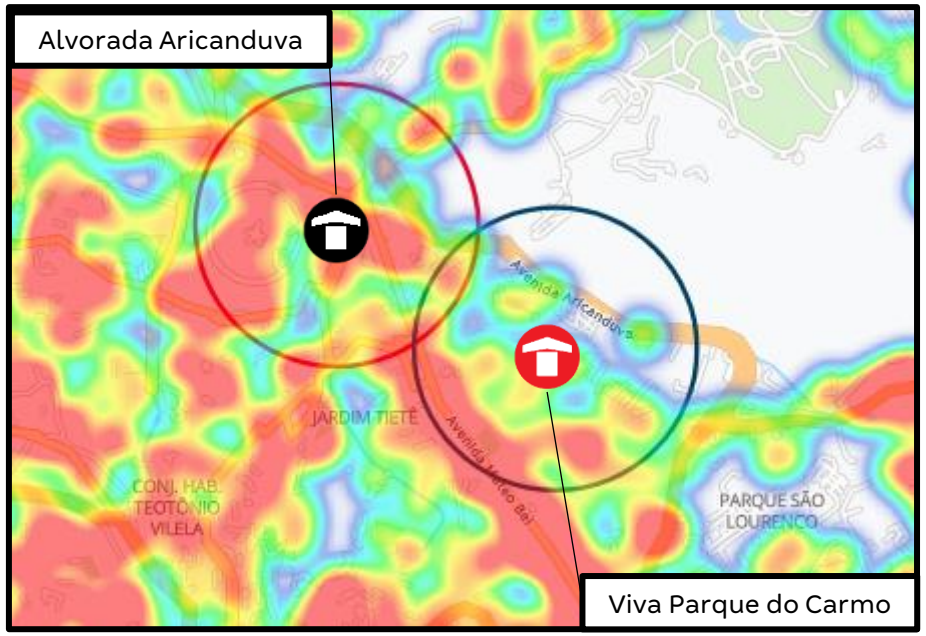

	Viva Parque do Carmo	Alvorada Aricanduva
Avaliação	239.500	248.000

One Page – Alvorada Aricanduva – Aprovação

Cidade	São Paulo	Mancha de demanda	SP - SZL1 - São Paulo Leste 1
Regional	SP	Cluster MPR	2 - Amarelo
Cenário de Aprovação	Aprovação	Tipo de Aprovação	Consolidado
Fase Anterior	N/A		
Tipo de Comitê	Lançamento	Versão da VF	Versão 1.0: Ago

[1] Unidades (Fases)	577 (1)	CA Máx | Proj	7,2 | 4,5
Unidades com Vaga (%)	0 (0%)	Escritura | Lançamento	set/25 | set/25
Unidades com Atributo* (%)	0 (0,0%)	Tipologia	F2E Plus - CDW

[2] Valor Líquido do Terreno (% VGV)	11.700 (8,6%)	Un. Perm. Fís (% Ter)	0 (0,0%)
Cash (Correção)	450 (N/A)	%VGV Perm Fin Líquida (% Ter)	8,3% (96,2%)
Valor R$/m²	3.608	VAR (%VGV)	000 (0,0%)

[3] Custo Construção (%VGV)	60.613 (44,6%)	Indireto Unit.	19.279
Prazo da Obra (meses)	23	Torre Unit.	64.326
Custo Total Unit. (LPU):	105.049 (93)	Infra Unit.	9.269
Início de Obra	mar-26	Fundação Unit.	9.563

[4] Preço Nominal Unit.	235.485	VSO	32
Preço Raso Unit.	220.993	Referência	VISION
Avaliação Unit.	248.000	Renda (% em RET 1%)	3.648 (25,0%)

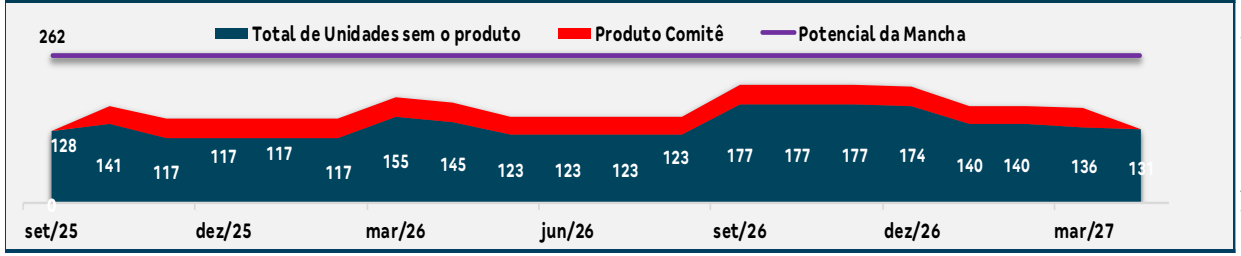

LI (Régua):	20,0% (20,0%)	Margem Bruta Econômica:	36,5%
LI Marginal:	20,6%	Margem Rasa Econômica:	31,8%
Margem Bruta REF:	40,1%	Margem Contribuição Econômica:	25,8%
Margem Rasa REF:	36,1%	Exposição (% VGV):	9.982 (7,4%)
TIR:	146,7%	VGV Total:	135.875
Payback Contingente (21 m) :	19 m/ (-2 m)	Ger. Caixa 12 meses (R$):	(8.194)
Payback Consolidado:	19	Ger. Caixa 24 meses (R$):	14.090

*Atributo: Varanda, Garden e Churrasqueira

Destaques

[1] Projeto: O Terreno possui área de 4.257m², localizado na Rua Estado do Ceara, mancha ZL1 ao lado do empreendimento Ouro Preto da Tenda, entregue em 2024. O projeto é composto por 1 condomínio, 2 torres de 12pp, tipologia F2E+ CDW (t+23/t+24) e zero vagas. A partir do coeficiente máx de aproveitamento de 7,2X, o projeto atingiu 4,5x, sendo que quando descontamos área áreas não implantáveis do terreno (APP, FNA e taludes), chegamos em um CA líquido de 5,8X. Devido aos limites das faixas envoltórias (distanciamento mínimo) entre as torres, não foi possível chegar ao t+25. Testamos diversas implantações, inclusive a torre em L, porem esta configuração foi a que melhor adensou o terreno.

[2] Condição Comercial: Valor total de R$11,7MM, sendo 96% em P.Fin. e 4% Cash; Sem garantia (aval Tenda)

- **Sinal –** R$450.000 já pagos em 10 mensais fixas e irreajustáveis de R$45K com inicio em set/24 e finalizado em jun/25.
- **Permuta Financeira (Preço Certo fixo e irreajustável) -** R$ 11.250.000 a serem pagos através do repasse fixo de 12,30% dos recebíveis. Caso o proprietário não receba o Preço Certo em até 46 meses do início da obra, a Tenda fará a quitação em parcela única no mês subsequente; como o projeto teve um aumento de unidades e ainda com a atualização dos preços de venda a fração efetiva será de 8,6%, no entanto, os valores correspondentes ao pagamento mensal no fluxo de caixa, continuam conforme contrato com 12,3% do valor recebido mês a mês e será encerrado no atingimento do preço certo;
- **Pagamento IPTU** – Está previsto em viabilidade uma antecipação da permuta no valor de R$ 500.000 referente a quitação de débitos de IPTU do proprietário, que até o atual momento se encontra no valor de R$453.761,43, podendo sofrer reajustes até a data do pagamento e por isso consideramos um valor excedente. Esse valor será descontado dos recebíveis iniciais da permuta, com acréscimo de 18% a.a. até a sua quitação, calculados desde a data do pagamento até a data de cada desconto.

[3] Custo: Custo total de R$105.049/unid. Foi considerado reembolso pela SABESP, no valor de R$126mil com pagto 6 seis meses após término obra. O valor refere-se a 40% do custo total orçado na folha rosto pela Tenda para a construção das redes de infra. O % de reembolso considerado se baseia na tabela de "Custos Sabesp", tomando como parâmetro os custos de reembolso aferidos pelos projetos das obras Max Vila Sonia e Citta Vila Prudente, conforme tabela abaixo. A modalidade de reembolso faz parte do ctr de privatização da SABESP, e estipula que, a mesma restituirá os custos de execução das redes executados pelo incorporador. A SABESP tem a opção de executar ou proceder posteriormente com o reembolso; importante destacar que neste ano já tivemos a execução integral pela SABESP de 5 obras totalizando aprox. 3MM que estavam de responsabilidade da Tenda. A SABESP tem demonstrado priorização pela execução, e inclusive o Max Vila Sonia estamos aguardando a formalização de execução de 100% das redes antes do lançamento. Apesar de pouco provável dado os casos indicados, caso a Sabesp dê a negativa integral, teríamos um impacto de 0,09 pp na LI.

OBRA	FR	TABELA SABESP	%
MAX VILA SONIA	2.475.900	1.047.289	42%
CITTA VILA PRUDENTE	2.677.467	984.162	37%
			39%

[4] Preço de venda: Adotando a regra de ouro com folga de início de 6 meses, gerando um PSOL de 28 meses; 18 meses de venda com VSO de 32; o preço foi definido com base na referência da região e no empreendimento Tenda Viva Parque do Carmo e aplicado elasticidade sobre o preço real. A mancha tem demanda para os dois empreendimentos e adotamos assim como em outros projetos na ZL a estratégia de "escadinha" pelas localizações na diferenciação de preços, afastando o risco de canibalização.

One Page – Alvorada Aricanduva – Real

Cidade	São Paulo	**Mancha de demanda**	SP - SZL1 - São Paulo Leste 1
Regional	SP	**Cluster MPR**	2 - Amarelo
Cenário de Aprovação	Real	**Tipo de Aprovação**	Consolidado
Fase Anterior	N/A		
Tipo de Comitê	Lançamento	**Versão da VF**	Versão 1.0: Ago

Unidades (Fases)	577 (1)	**CA Máx | Proj**	7,2 | 4,5
Unidades com Vaga (%)	1 (0%)	**Escritura | Lançamento**	set/25 | set/25
Unidades com Atributo* (%)	0 (0,0%)	**Tipologia**	F2E Plus - CDW

Valor Líquido do Terreno (% VGV)	11.700 (8,6%)	**Un. Perm. Fís (% Ter)**	0 (0,0%)
Cash (Correção)	450 (N/A)	**%VGV Perm Fin Líquida (% Ter)**	8,3% (96,2%)
Valor R$/m²	3.608	**VAR (%VGV)**	000 (0,0%)

[1]

Custo Construção (%VGV)	60.613 (44,8%)	**Indireto Unit.**	19.279
Prazo da Obra (meses)	23	**Torre Unit.**	64.326
Custo Total Unit. (LPU):	105.049 (93)	**Infra Unit.**	9.269
Início de Obra	dez-25	**Fundação Unit.**	9.563

[2]

Preço Nominal Unit.	234.664	**VSO**	32
Preço Raso Unit.	217.861	**Referência**	VISION
Avaliação Unit.	248.000	**Renda (% em RET 1%)**	3.658 (25,0%)
Fase de Lançamento - Uso exclusivo para o Ciclo Financeiro		**Preço Raso Inf. Médio Unit.**	222.310
Preço Inf. Médio Unit.	239.437	**Margem Bruta REF (%)**	40,5%
Custo Inf. Médio Unit.	142.515	**Margem Rasa REF (%)**	35,9%

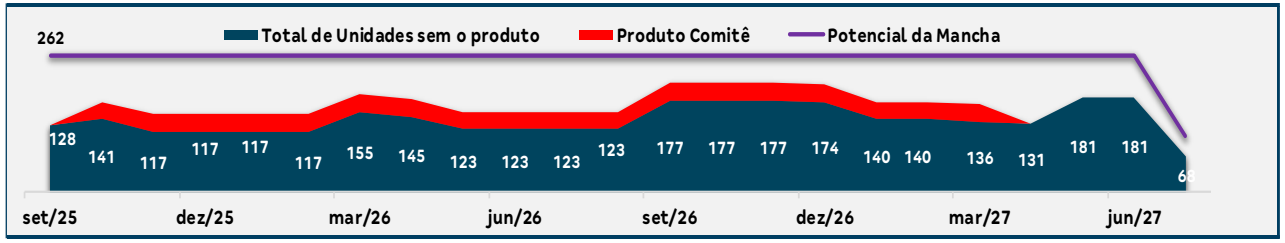

LI (Régua):	**19,5% (20,0%)**	**Margem Bruta Econômica:**	36,9%
LI Marginal:	20,1%	**Margem Rasa Econômica:**	31,4%
Margem Bruta REF:	40,5%	**Margem Contribuição Econômica:**	26,2%
Margem Rasa REF:	**35,9%**	**Exposição (% VGV):**	13.375 (10,0%)
TIR:	123,7%	**VGV Total:**	**135.401**
Payback Contingente (21 m) :	**19 m/ (-2 m)**	**Ger. Caixa 12 meses (R$):**	(12.389)
Payback Consolidado:	19	**Ger. Caixa 24 meses (R$):**	17.507

***Atributo: Varanda, Garden e Churrasqueira**

Destaques

[1] Geral:
Todas as observações do slide anterior do cenário aprovação, são aplicáveis para este slide do cenário real. A única diferença entre os cenários, é a folga de início da regra de ouro (aprovação) X cenário do PCP 167 (real), impactando o prazo de PSOL e por consequência no Preço de venda.

[2] Preço de venda
Adotando o PCP 167, gerando um PSOL de 25 meses; 18 meses de venda com VSO de 32.

- Pareceres
- Análise da Mancha e Implantação
- Prospecção
- Operações
- Inteligência de Mercado
- Financeiro

Faróis Pareceres – Alvorada Aricanduva

Área	Riscos Associados	Parecer	Criticidade
Jurídico Aquisição	Seguiremos com a escritura do terreno já com aditivo contratual assinado em 01.09.25 junto ao vendedor, regrando a retenção dos recebíveis da permuta até o atingimento de 2,5MM, de modo a fazer frente a eventual condenação na execução em trâmite atualmente em ~1,7MM. Referido valor ficará retido até a integral quitação do vendedor com o credor da ação, e devida extinção do processo.	Ok	
Jurídico Imobiliário	Considerado a estratégia e situação precedente, de seguirmos com o registro de incorporação com apresentação da dispensa de Graprohab posteriormente em prazo pré-determinado junto ao cartório, e sem risco a contratação junto a CEF. Aguardando escritura do terreno e alvará do projeto.	Ok	
Legalização	Aguardando Projeto Aprovado SABESP (com previsão para o dia 21/10/2025) para Dispensa de Análise de GRAPROHAB.	Ok	
Produto	Não há riscos associados.	Ok	
Logística	Obrigatório uso de licença de tapume durante todo o período de obra.	Ok com ressalvas	
Contratação	Laudo engenharia previsto para 20/09 com pendência de RI e sem pendência em 07/10. Risco previsto para 08/10 e retorno da análise juridica em 09/10.	OK com ressalvas	
Inteligência de mercado	IM avalia o Preço Vision como factível.	Ok	
Comercial/Ciclo	Preço e VSO viáveis.	Ok	
Estudos Econômicos	Sem riscos.	Ok	

Pareceres

Análise da Mancha e Implantação

Prospecção

Operações

Inteligência de Mercado

Financeiro

Macrolocalização – Rua Estado do Ceará, 1186 – Jd. Egle

Mancha de Demanda

MANCHAS DE DEMANDA

• SZL – São Paulo Leste

Lançamento

1. Viva São Miguel
2. Viver Bem | Mais USP Leste
3. Viva Parque do Carmo
4. Reserva das Andorinhas
5. Palermo
6. Oásis Penha

LandBank

7. Lar de Itaquera | Sol de Itaquera
8. Viva Azul
9. Tucumã
10. Residencial Tóquio | Quioto
11. Jerivás
12. Alvorada Aricanduva
13. Amarilis
14. Aurora

Cluster MPR – (Comitê)

Cluster 2 - Amarelo

Região

Capital

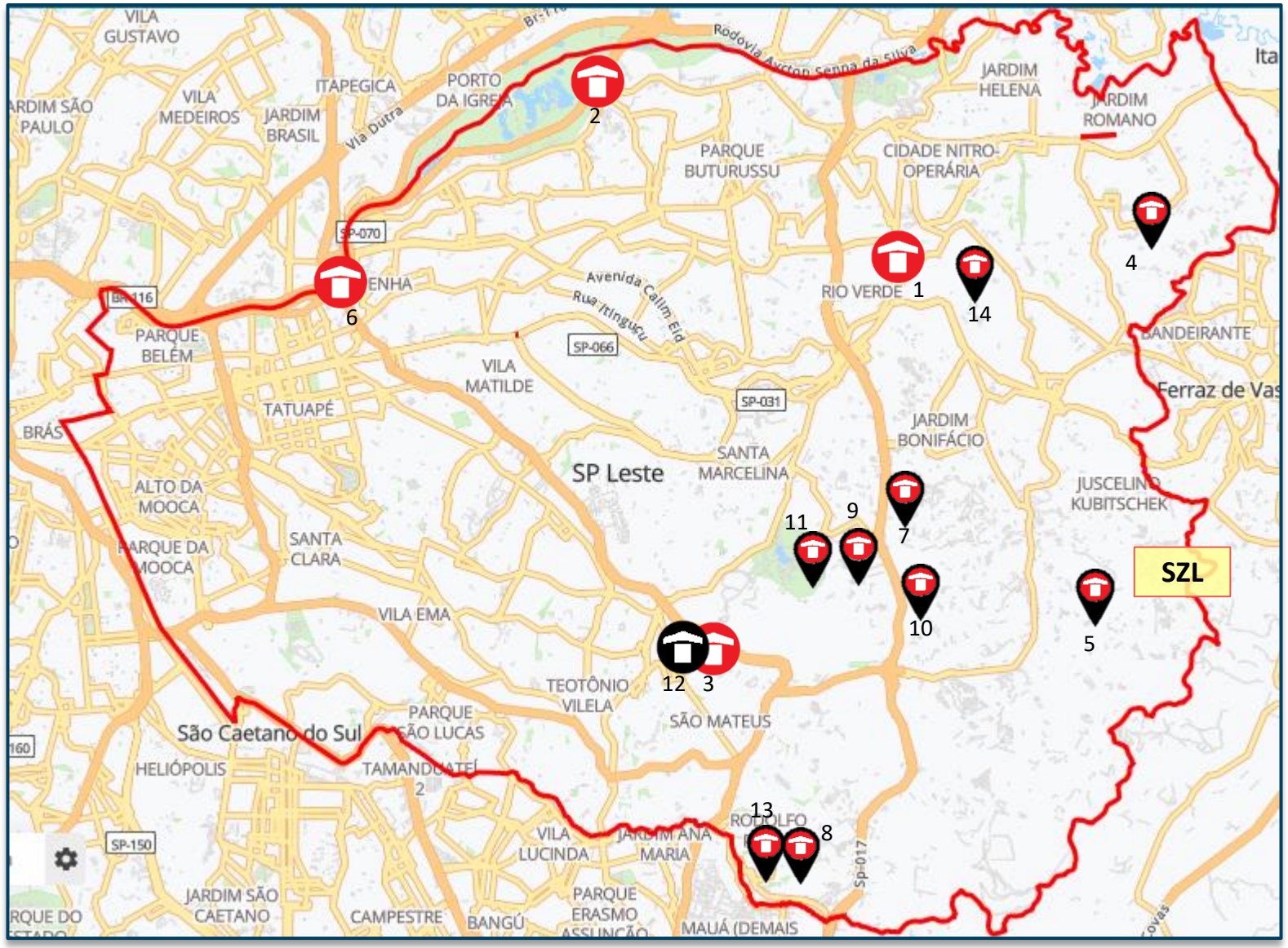

Lançados *LandBank* *Comitê*

Macrolocalização – Rua Estado do Ceará, 1186 – Jd. Egle

Macrolocalização – Rua Estado do Ceará, 1186 – Jd. Egle

PRODUTO

Projeto Alvorada Aricanduva
Escritura e Lançamento

Informações Gerais – Condomínio Único			
Terreno	Área do terreno	4.257,30m²	
	APP | Reserva de calçada	576,83 | 168,32	
	Área Non Aedificandi	234,41m²	
	Área liquida	3.277,74m²	
	Zoneamento	ZEIS-2	
	CA máximo	7,20	ZONA: 4,00
			INCENTIVO HIS: 2,00
			COTA: 1,20
	CA projetado	4,50	
	Gabarito máximo	N/A	
Geral	Total UH	577	
	Total de vagas	1 (1x PCD / C/D)	
Tipologia	Tipologia	SP-0200-LF-CD15-CE1A-12PP	
	Gabarito	T+24 | T+23	
	Lâmina	02 X 12PP-LF	
	Área privativa	31,84m²	
Condomínio	Unidade PCD	18	
	Unidade lazer | técnica	09 | 02	
	Torre	02	
	Fase	Única	
Lazer	Lazer coberto	Espaço Office, Salão de Festas Gourmet, Fitness, Espaço Saúde, Brinquedoteca, Espaço Teen, Sport Bar, Churrasqueira, Mini market/delivery	
	Lazer descoberto projetado	Praça de chegada, Play Kids, Play Baby, Play Pet, Multiestações	

ÁREAS DE LAZER

- 01 PRAÇA DE CHEGADA
- 02 BICICLETÁRIOS
- 03 CHURRASQUEIRA GOURMET
- 04 ESPAÇO OFFICE
- 05 SALÃO DE FESTAS GOURMET
- 06 SPORT BAR
- 07 ESPAÇO TEEN
- 08 PLAY BABY
- 09 PLAY KIDS
- 10 FITNESS
- 11 ESPAÇO SAÚDE
- 12 ESPAÇO MINI MARKET / DELIVERY
- 13 BRINQUEDOTECA
- 14 MÚLTIPLA ESTAÇÃO
- 15 PLAY PET

INFRAESTRUTURA

- 16 PORTARIA COM PORTÃO DUPLO DE SEGURANÇA

ÁREAS DE CIRCULAÇÃO

- ACESSO DE PEDESTRES
- ACESSO DE VEÍCULOS
- ACESSO AO HALL SOCIAL
- ACESSO SERVIÇO

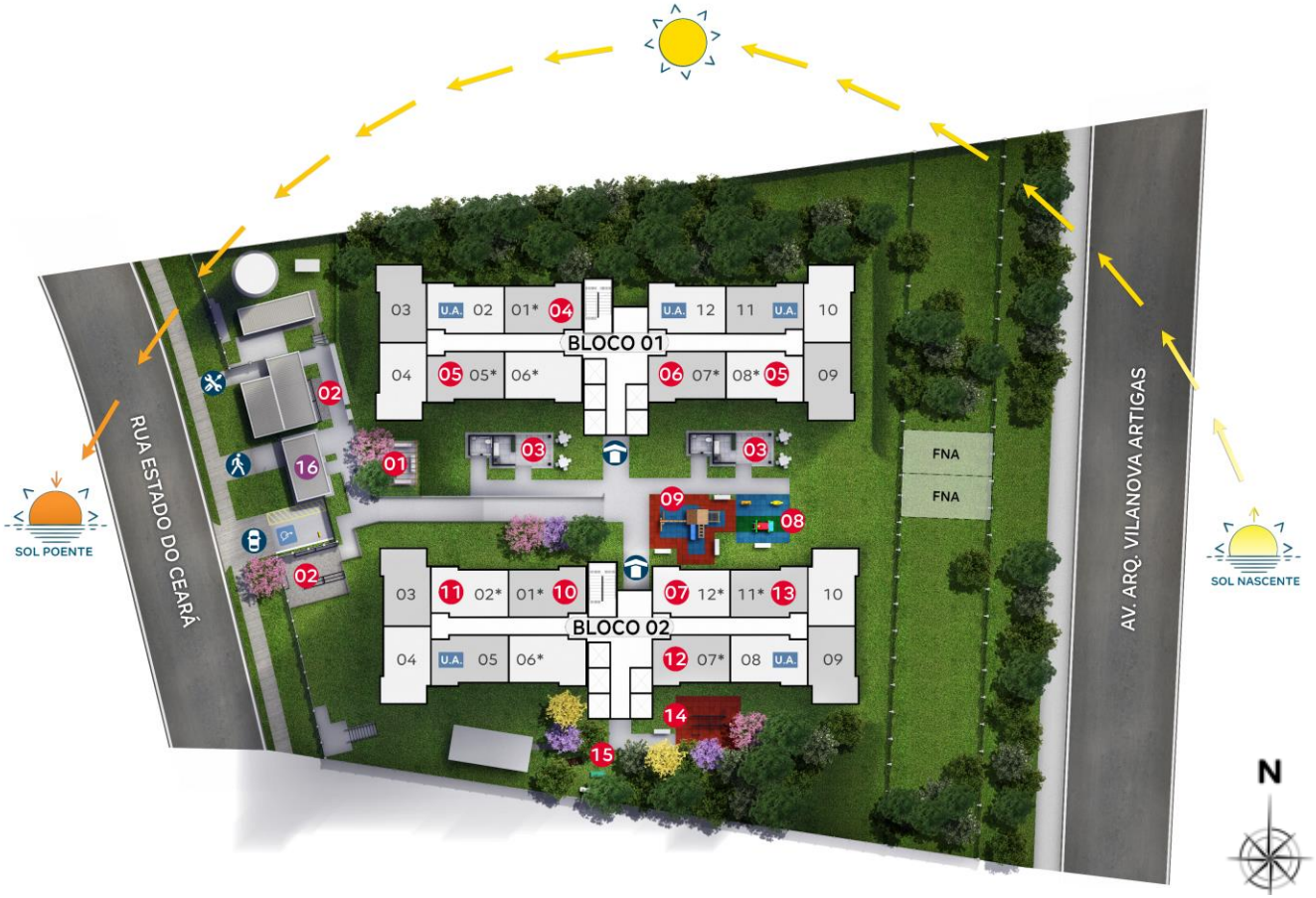

ANTEPROJETO

A partir do coeficiente máx de aproveitamento de 7,2X, o projeto atingiu 4,5x, sendo que quando descontamos as áreas não implantáveis do terreno (APP, FNA e taludes), chegamos em um CA líquido de 5,8X. Devido aos limites das faixas envoltórias (distanciamento mínimo entre torres) , não foi possível chegar ao t+25. Testamos diversas implantações, inclusive a torre em L, porem esta configuração foi a que melhor adensou o terreno.

PRODUTO

Projeto Alvorada Aricanduva
Escritura e Lançamento

	Descrição	Criticidade	Parecer
Usabilidade	Acesso Empreendimento		
	Percurso do pedestre até torre		
Diferencial produto	Prime	Não	
	Supercondomínio	Não	
	Atributos Infra	Não	
	Atributos Torre	Não	
	Edifício Garagem	Não	

	Riscos associados	Parecer	Criticidade
Produto	Não há riscos associados	ok	

Projeto Alvorada Aricanduva
Escritura e Lançamento

Fase única: 577uh (sendo 18 PCD)				
Módulo	**Blocos**	**UH**	**Vagas**	**Parecer**
Módulo 01	Blocos 01 (T+24)	295 Uh (Sendo 9 PCD)	-	Dos Lazeres estão contemplados no modulo 01 Play Baby, Play Pet e Churrasqueiras.
Módulo 02	Blocos 02 (T+23)	282 UH (Sendo 9 PCD)	-	Dos Lazeres, esta contemplado no módulo 02 o Play Pet e Multiestações.

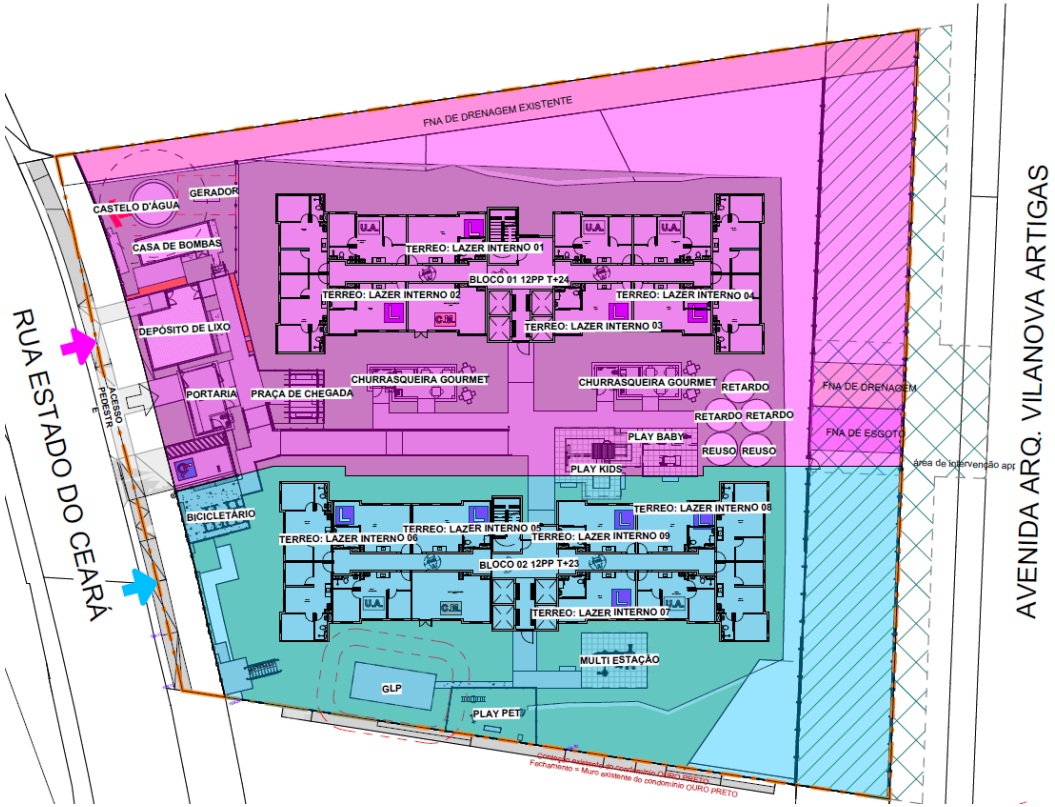

Pareceres

Análise da Mancha e Implantação

Prospecção

Operações

Inteligência de Mercado

Financeiro

Condições do Negócio – Alvorada Aricanduva

➢ **VALOR DO NEGÓCIO**
- R$ 11.700.000,00 (Onze milhões e setecentos mil reais)

➢ **CONDIÇÃO**
- 96% Permuta Financeira
- 4% em dinheiro

➢ **FORMA DE PAGAMENTO**
- Cash: R$ 450.000 (quatrocentos e cinquenta mil reais) em 10 (dez) parcelas fixas e irreajustáveis sendo a primeira parcela paga após a superação da primeira tranche de resolutivas.
- Permuta Financeira: R$11.250.000 (Onze milhões e duzentos e cinquenta mil reais) como **preço certo** pago através do repasse mensal de 12,3% sobre o VGV Bruto. Caso o valor não seja atingido em até 46 meses após o início das obras, o permutante poderá acionar a cláusula de quitação do saldo.
- Desconto dos valores referente a débitos de IPTU, das parcelas vincendas do preço com acréscimo de uma taxa de 18% ao ano.

➢ **PRAZOS CONTRATUAIS**
- Etapa I – Até 90 dias da assinatura do CVC, assinado em 22/05/2024;
- Etapa II - Em até 10 meses após a superação da etapa I, aprovação de projeto, contratação CEF e viabilidade técnica e financeira.

➢ **GARANTIAS**
- Tenda: N/A
- Vendedor: Aval Tenda

➢ **ESCRITURA**
- Em até 10 meses da superação das condições resolutivas da Etapa "I". (Previsão ago/25)

➢ **CORREÇÃO MONETÁRIA**
- N/A

➢ **CORRETAGEM**
- 6% do valor da aquisição - R$702.000,00, pagos um mês após a superação de todas as condições resolutivas e a escrituração do imóvel em 6 parcelas.

Condições do Negócio – Alvorada Aricanduva

➢ **CONDIÇÕES RESOLUTIVAS:**

I – Em até 90 (noventa) dias a contar da assinatura do presente instrumento: (Prazo até 22/Ago)

1. a existência de ação de desapropriação e/ou declaração de utilidade pública que objetive o Imóvel ou parte dele; **SUPERADO**
2. a existência de cadastro como imóvel tombado e/ou em processo de tombamento e/ou em áreas envoltórias, no IPHAN, CONDEPHAAT ou CONPRESP, que impossibilitem a adequada consecução do Empreendimento Imobiliário; **SUPERADO**
3. a não apresentação da documentação e/ou esclarecimentos indicados nas cláusulas 3.1, 3.2, 3.2.1 e 3.4 e no ANEXO I pela VENDEDORA no prazo ali indicado e/ou a existência de qualquer apontamento nos documentos e certidões forenses que objetive, onere e/ou possa trazer vício à cadeia dominial do Imóvel e/ou possam reduzir a VENDEDORA ao estado de insolvência civil, ou que traga insegurança jurídica na operação objeto deste instrumento, a exclusivo critério da COMPRADORA; **SUPERADO**
4. a impossibilidade da realização do estudo de passivo ambiental ou a existência de qualquer tipo de contaminação do solo, subsolo e águas do Imóvel, bem como qualquer outro tipo de passivo ambiental e/ou impossibilidade de remoção de árvores que comprometam o Empreendimento que a COMPRADORA pretende desenvolver no Imóvel; **SUPERADO**
5. a existência de óbice e/ou condições técnicas impeditivas à consecução do Empreendimento imobiliário almejado pela COMPRADORA no Imóvel; **SUPERADO**
6. a não viabilidade das redes de água e esgoto existentes no local, que sejam tidas como insuficientes a garantir a vazão necessária às unidades autônomas que comporão o Empreendimento pretendido; **SUPERADO**
7. a não viabilidade de rede elétrica para abastecimento do futuro Empreendimento; **SUPERADO**
8. a não viabilidade de execução da drenagem ou não permissão de passagem em terreno de terceiros; **NÃO SE APLICA**
9. caso o gabarito de altura pretendido para o Empreendimento não seja aprovado no DECEA (Departamento de Controle do Espaço Aéreo) e COMAER (Comando da Aeronáutica); **SUPERADO**
10. caso o presente negócio não seja aprovado pelo Comitê de Investimentos da COMPRADORA; **SUPERADO**

➢ CONDIÇÕES RESOLUTIVAS:

II – ETAPA II: em até 10 (dez) meses contados da superação das condições resolutivas ETAPA 1: (Prazo até set/25)

1. caso as partes não logrem promover eventuais regularizações relativas ao Imóvel, necessárias para a consecução do Empreendimento pretendido;
2. o não aperfeiçoamento de quaisquer das condições resolutivas, relativas ao terreno e ao Empreendimento, abaixo relacionadas:
   I. Análise da viabilidade técnica e financeira do Empreendimento;
   II. Análise da viabilidade comercial do Empreendimento;
   III. Verificação da manutenção da segurança jurídica, contemplando a análise das certidões da VENDEDORA e do Imóvel, nos termos da Cláusula 3.5, supra.
3. a não aprovação nos termos da legislação vigente do projeto do Empreendimento junto à Prefeitura Municipal e demais órgãos competentes, necessários para viabilizar sua edificação, mediante a obtenção de todas as licenças necessárias para tal fim e/ou exigências pela Prefeitura Municipal de obrigações adicionais não contempladas no projeto apresentado e/ou de contrapartida que acarrete a inviabilidade financeira do Empreendimento pretendido pela COMPRADORA;
4. a inviabilidade de contratação de financiamento pela instituição financeira para construção do Empreendimento, consoante os termos e condições do Programa do Governo Federal Minha Casa Minha Vida ou qualquer outro que venha a substituí-lo; e
5. caso seja constatada pela COMPRADORA a existência de terceiros ocupantes no Imóvel, existindo pessoas e coisas, que impeçam a transferência da posse para a COMPRADORA de forma inteiramente livre e desimpedida, nos termos previstos no presente instrumento.
6. No caso da não superação de quaisquer das Condições Resolutivas, a COMPRADORA poderá, ao seu exclusivo critério, optar por: (i) dar por superada a respectiva condição; (ii) manter vigente o presente instrumento, suspendendo, contudo, os prazos contratuais, pelo prazo que for necessário para que se regularize a situação, caso em que o presente instrumento permanecerá válido e eficaz, suspendendo-se o pagamento do Preço, incluindo as parcelas vincendas do Sinal e a lavratura da competente Escritura de Venda e Compra, sendo certo que não haverá a incidência de quaisquer penalidades ou multas; ou (ii) dar por rescindido o presente negócio, sem qualquer penalidade de parte a parte, ressalvadas as hipóteses previstas na Cláusula 6.5., infra.

- **CONDIÇÕES RESOLUTIVAS:**

II – ETAPA II: em até 10 (dez) meses contados da superação das condições resolutivas ETAPA 1: (Prazo até set/25)

1. Na hipótese deste instrumento vir a ser resolvido por ocorrência da não implementação de alguma das Condições Resolutivas, a exclusivo critério da COMPRADORA, as Partes deverão retornar ao status quo anterior ao de sua assinatura, ressalvadas eventuais regularizações relacionadas ao Imóvel, realizadas para fins de superação das referidas Condições Resolutivas, não sendo devida qualquer indenização ou penalidade, por uma parte à outra, exceto nas hipóteses previstas na Cláusula 6.5, infra.
2. As Partes estão cientes e de acordo com o fato de que todas as Condições Resolutivas elencadas na Cláusula 6.1, supra, são instituídas em benefício da COMPRADORA, razão pela qual poderá a COMPRADORA considerar qualquer das condições superadas a qualquer tempo, confirmando o presente negócio, o que se caracterizará com o envio de uma notificação neste sentido, não podendo a VENDEDORA negar-se, sob qualquer pretexto, a dar prosseguimento ao negócio.

- Pareceres
- Análise da Mancha e Implantação
- Prospecção
- Operações
- Inteligência de Mercado
- Financeiro

Custo de Construção

	SOBRAL R02	SOBRAL R01	SOBRAL R00	SOBRAL PARAMETRIZAÇÃO	PQ. LIMÃO LVS
Torres	2	2	2	2	2
Unidades Construídas	588	588	588	588	832
Unidades Vendidas	577	577	577	577	823
Cidade	São Paulo - SP	São Paulo - SP	São Paulo - SP	São Paulo - SP	São Paulo - SP
Produto / Selo	F2EPlus - V0200 CDW	F2EPlus - V0200 CDW	F2EPlus - V0200 CDW	F2EPlus - V0200 CDW	SP-F2E Plus
Tipologia	1 Torre | T+23 | 12PP	1 Torre | T+23 | 12PP	1 Torre | T+23 | 12PP	1 Torre | T+23 | 12PP	1 Torre | 16PP | T+25
Tipologia	1 Torre | T+24 | 12PP	1 Torre | T+24 | 12PP	1 Torre | T+24 | 12PP	1 Torre | T+24 | 12PP	1 Torre | 16PP | T+25
Projeto Infra	EP	EP	EP	AP	
Projeto Torre	AP	AP	AP	AP/EM	
Mês Base	agosto-25	agosto-25	agosto-25	janeiro-25	junho-25
Incc	1.199,509	1.199,509	1.199,509	1.159,536	
LVS	junho-25	junho-25	junho-25	novembro-24	
Indiretos	junho-25	junho-25	junho-25	novembro-24	
Base de Preço	LPU 93	LPU 93	LPU 93	LPU 86	
Takt	2x2	2x2	2x2	2x2	
Prazo (mês)	23	23	23	23	24
CUSTO TOTAL I	R$ / UND R$ 104.242	R$ / UND R$ 104.450	R$ / UND R$ 105.732	R$ / UND R$ 100.450	R$ / UND R$ 101.714
Indireto	R$ 19.279	R$ 19.279	R$ 19.837	R$ 19.100	R$ 19.052
Torre	R$ 64.326	R$ 64.534	R$ 64.863	R$ 63.620	R$ 64.504
Infra	R$ 9.269	R$ 9.269	R$ 9.329	R$ 9.578	R$ 9.972
Fundação	R$ 9.563	R$ 9.563	R$ 9.899	R$ 6.827	R$ 7.468
EEE					
ETE					
Contenção	R$ 1.100	R$ 1.100	R$ 1.100	R$ 364	R$ 90
Terraplenagem	R$ 704	R$ 704	R$ 704	R$ 960	R$ 628
CUSTO TOTAL II	R$ 807	R$ 807	R$ 807	R$ 1.326	
Urbanização				R$ 133	
Drenagem				R$ 15	
Extensão de Rede Elétrica	R$ 260	R$ 260	R$ 260	R$ 234	
Extensão de Rede Hidráulica	R$ 547	R$ 547	R$ 547	R$ 944	
CUSTO TOTAL III	R$ 0	R$ 0	R$ 0		
Incorridos	R$ 0	R$ 0	R$ 0		
CUSTO TOTAL IV					
Aprendizado					
CUSTO TOTAL IV				R$ 3.510	
Atualização por INCC				R$ 3.510	
CUSTO TOTAL I+II	R$ 105.049	R$ 105.257	R$ 106.539	R$ 101.809	R$ 101.714
CUSTO TOTAL I AO IV	R$ 105.049	R$ 105.257	R$ 106.539	R$ 105.286	R$ 101.714

Custo de Construção

	SOBRAL R02	SOBRAL R00	
Torres	2	2	
Unidades Construídas	588	588	
Unidades Vendidas	577	577	
Condomínios (qta.)	1	1	
Cidade	São Paulo - SP	São Paulo - SP	
Produto / Selo	F2EPlus - V0200 CDW	F2EPlus - V0200 CDW	
Tipologia	1 Torre | T+23 | 12PP	1 Torre | T+23 | 12PP	
Tipologia	1 Torre | T+24 | 12PP	1 Torre | T+24 | 12PP	
Projeto Infra	EP	EP	
Projeto Torre	AP	AP	
Mês Base	agosto-25	agosto-25	
Incc	1199,509	1199,509	
LVS	junho-25	junho-25	
Indiretos	junho-25	junho-25	
Base de Preço	LPU 93	LPU 93	
Takt	2x2	2x2	
Prazo (mês)	23	23	
CUSTO TOTAL I	R$ / UND R$ 104.242	R$ / UND R$ 105.732	DIF -R$ 1.490
Indireto	R$ 19.279	R$ 19.837	-R$ 558
Torre	R$ 64.326	R$ 64.863	-R$ 537
Infra	R$ 9.269	R$ 9.329	-R$ 59
Fundação	R$ 9.563	R$ 9.899	-R$ 336
EEE	R$ 0	R$ 0	R$ 0
ETE	R$ 0	R$ 0	R$ 0
Contenção	R$ 1.100	R$ 1.100	R$ 0
Terraplenagem	R$ 704	R$ 704	R$ 0
CUSTO TOTAL II	R$ 807	R$ 807	R$ 0
Urbanização	R$ 0	R$ 0	R$ 0
Drenagem	R$ 0	R$ 0	R$ 0
Extensão de Rede Elétrica	R$ 260	R$ 260	R$ 0
Extensão de Rede Hidráulica	R$ 547	R$ 547	R$ 0
CUSTO TOTAL III	R$ 0	R$ 0	
Incorridos	R$ 0	R$ 0	R$ 0
CUSTO TOTAL IV	R$ 0	R$ 0	
Aterro Pré Carga	R$ 0	R$ 0	R$ 0
CUSTO TOTAL IV	R$ 0	R$ 0	
Atualização por INCC	R$ 0	R$ 0	R$ 0
CUSTO TOTAL	R$ 105.049	R$ 106.539	-R$ 1.490

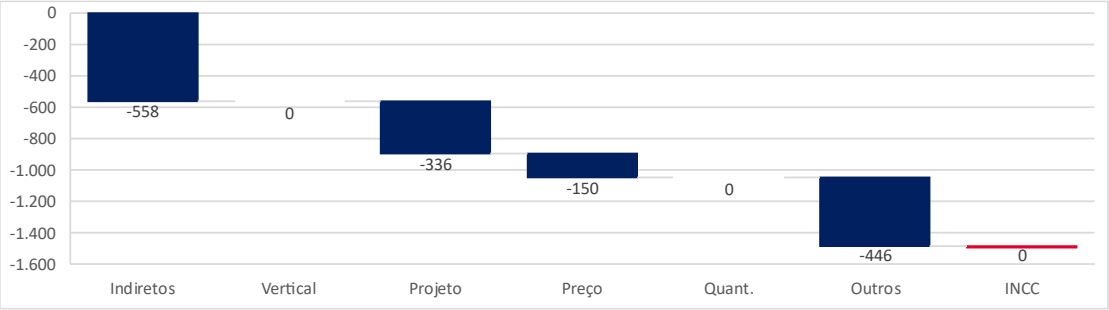

INDIRETOS
-558 | Retroalimentação

PROJETO
-336 | Fundação

PREÇO
-150 | Preparo e regularização do poço

OUTROS
-208 | Preparo e Regularização do poço
-179 | Ferragens porta
-59 | Reservatório Metálico

Custo de Construção

	SOBRAL R02	SOBRAL PARAMETRIZAÇÃO	
Torres	2	2	
Unidades Construídas	588	588	
Unidades Vendidas	577	577	
Condomínios (qta.)	1	1	
Cidade	São Paulo - SP	São Paulo - SP	
Produto / Selo	F2EPlus - V0200 CDW	F2EPlus - V0200 CDW	
Tipologia	1 Torre | T+23 | 12PP	1 Torre | T+23 | 12PP	
Tipologia	1 Torre | T+24 | 12PP	1 Torre | T+25 | 14PP	
Projeto Infra	EP	AP	
Projeto Torre	AP	AP/EM	
Mês Base	agosto-25	janeiro-25	
Incc	1199,509	1159,536	
LVS	junho-25	novembro-24	
Indiretos	junho-25	novembro-24	
Base de Preço	LPU 93	LPU 86	
Takt	2x2	2x2	
Prazo (mês)	23	23	
CUSTO TOTAL I	R$ / UND R$ 104.242	R$ / UND R$ 100.450	DIF R$ 3.791
Indireto	R$ 19.279	R$ 19.100	R$ 178
Torre	R$ 64.326	R$ 63.620	R$ 706
Infra	R$ 9.269	R$ 9.578	-R$ 309
Fundação	R$ 9.563	R$ 6.827	R$ 2.737
EEE	R$ 0	R$ 0	R$ 0
ETE	R$ 0	R$ 0	R$ 0
Contenção	R$ 1.100	R$ 364	R$ 736
Terraplenagem	R$ 704	R$ 960	-R$ 256
CUSTO TOTAL II	R$ 807	R$ 1.326	-R$ 519
Urbanização	R$ 0	R$ 133	-R$ 133
Drenagem	R$ 0	R$ 15	-R$ 15
Extensão de Rede Elétrica	R$ 260	R$ 234	R$ 26
Extensão de Rede Hidráulica	R$ 547	R$ 944	-R$ 397
CUSTO TOTAL III	R$ 0	R$ 0	
Incorridos	R$ 0	R$ 0	R$ 0
CUSTO TOTAL IV	R$ 0	R$ 0	
Aterro Pré Carga	R$ 0	R$ 0	R$ 0
CUSTO TOTAL IV	R$ 0	R$ 3.510	
Atualização por INCC	R$ 0	R$ 3.510	-R$ 3.510
CUSTO TOTAL	R$ 105.049	R$ 105.286	-R$ 237

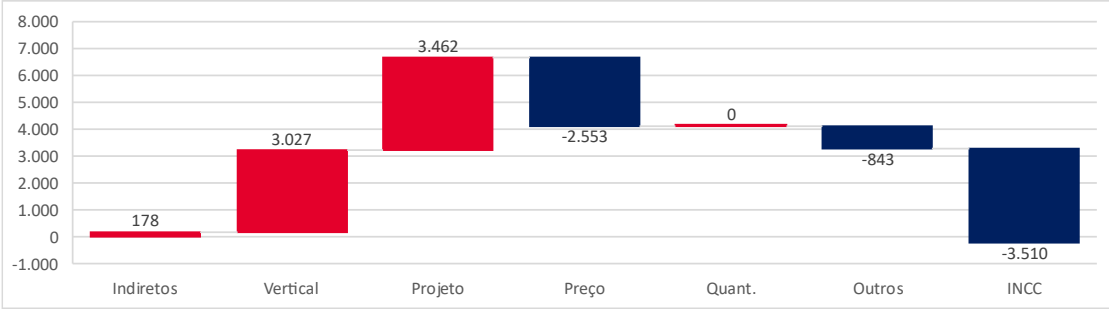

INDIRETOS
+195 | G13 Pessoal Permanente

VERTICAL
+3.027 | Retroalimentação (Dissídio + QLP)
Param: R$ 14.502 - 09/2024
Pré: R$ 17.054 - 06/25

PROJETO
+1.381 | Lajão x Baldrame
Pré: Concreto = 485m³ | Aço = 46.075,00kg
Param: Concreto = 185m³ | Aço = 35.868kg
+1.682 | Fundação Profunda
Pré: Ø50, Ø60, Ø70, Ø80 | 155unid. – Comp. 28m a 32m
Param: Ø60, Ø70, Ø80 | 98unid. – Comp. 25m
+1.696 | Aço Torre
Pré: 454.150kg | Taxa: 61 kg/m³
Param: 347.845kg | Taxa: 47,5 kg/m³
-1.204 | Elevador
+148 | Caixilho banheiros ponta
+736 | Contenção
-256 | Terraplenagem
-254 | Muro de Divisa
-118 | Reservatório Metálico

PREÇO
-2.685 | Elevador
+120 | Estrutura Formas
-397 | Extensão de rede hidráulica (cotação 08/2025)

OUTROS
-326 | Fundação Torre (equipamentos)
-148 | Urbanização + Drenagem (incluso no custo I)
-208 | Preparo e Regularização do poço

INCC
-3.510 | Atualização INCC

Operações

SISTEMA DE ABASTECIMENTO DE ÁGUA
Ligação de água na porta.

SISTEMA DE ESGOTAMENTO SANITÁRIO
Extensão de rede com diâmetro de Ø200mm, ligado ao PV da rede coletora de esgotos de Ø800mm existente na Avenida Arquiteto Nova Artigas.

DRENAGEM
Drenagem lançada por gravidade na sarjeta. (FNA interna).

SISTEMA DE ABASTECIMENTO DE GÁS
GLP.

TERRENO

Operações

Matriz Risco Concessionária	
Água	Nível 3
Esgoto	Nível 3
Drenagem	NA
Elétrica	NA
Gás	NA
Urbanização	NA

LEGENDA		
Nível	Tipo	Status
1	Com Diretriz	Conclusiva
2		Conclusiva com projeto aprovado
3		Conclusiva sem projeto aprovado
4		Não Conclusiva
5	Sem Diretriz	-
NA	-	Não aplicável

Água:
- Viabilidade emitida em 06/2025 com validade de 2 anos.

Esgoto:
- Viabilidade emitida em 06/2025 com validade de 2 anos.

Drenagem:
- Drenagem lançada por gravidade na sarjeta. (FNA interna).

Elétrica:
- No pedido de ligação definitiva a concessionária pode vir a cobrar reformas necessárias, caso a infraestrutura existente não seja suficiente.

Gás:
GLP.

Urbanização:
- Considerado calçada na testada do empreendimento.

Logística

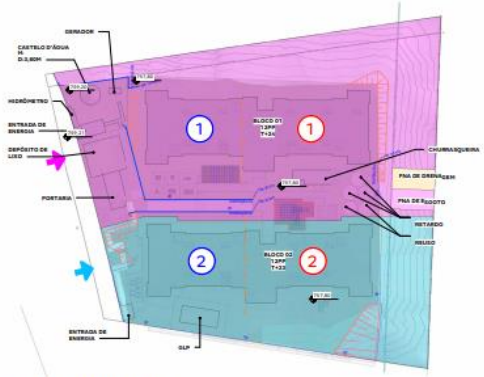

MODULAÇÃO E TOMBAMENTO
1 : 500

VIVÊNCIA - CONTAINERS									
DESCRIÇÃO	QUANTIDADE	TAMANHO MÓDULOS	MOBILIZAÇÃO	DESMOBILIZAÇÃO	PRÉ FORMA	ESTRUTURA	ACAB.	FASE	CÓDIGO ORÇAMENTO
CONTAINER PORTARIA (LOG)	CONSIDERAR 1 MÓDULO COM SANITÁRIO E CATRACA	2,41 X 4,90 m	1 MOBILIZAÇÃO	1 DESMOBILIZAÇÃO	TODO PERÍODO	TODO PERÍODO	TODO PERÍODO		
CONTAINER PROVISÓRIO (LOG)	CONSIDERAR 8 MÓDULOS DE CONTAINER	2,41 X 6,10 m	1 MOBILIZAÇÃO	1 DESMOBILIZAÇÃO	-	TODO PERÍODO	TODO PERÍODO		
CONTAINER PROVISÓRIO (LOG)	CONSIDERAR 8 MÓDULOS DE CONTAINER	2,41 X 6,10 m	1 MOBILIZAÇÃO	1 DESMOBILIZAÇÃO	TODO PERÍODO	-	-		

TENDAS_PERÍODOS								
DESCRIÇÃO	QUANTIDADE	LARGURA	COMPRIMENTO	PRÉ FORMA	ESTRUTURA	ACABAMENTO	FASE	CÓDIGO ORÇAMENTO
GAIOLA DE DESMOLDANTE (LOG)	1	2,00	2,00	-	TODO PERÍODO	-		
TENDA ARMADOR (LOG)	2	<varia>	<varia>	TODO PERÍODO	TODO PERÍODO	-		
TENDA LAZER (LOG)	1	4,77	6,08	-	TODO PERÍODO	TODO PERÍODO		

LOG_EQUIPAMENTOS E MAQUINÁRIOS								
EQUIPAMENTO	QUANTIDADE	MOBILIZAÇÃO	DESMOBILIZAÇÃO	PRÉ FORMA	ESTRUTURA	ACABAMENTO	FASE	CÓDIGO ORÇAMENTO
BETONEIRA (LOG)	VARIÁVEL	-	-	TODO PERÍODO	TODO PERÍODO	-		
BOBCAT (LOG)	1 EQUIPAMENTO	1 MOBILIZAÇÃO	1 DESMOBILIZAÇÃO	-	TODO PERÍODO	CONSIDERAR 15 DIAS DO PERÍODO DE ACABAMENTO		
BOMBA ESTACIONÁRIA PADRÃO (LOG)_R01	1 EQUIP PARA O BLOCO X	-	-	-	TODO PERÍODO	-		
CAMINHÃO MUNCK (LOG)	1 EQUIPAMENTO	1 MOBILIZAÇÃO	1 DESMOBILIZAÇÃO	-	CONSIDERAR MEIO PERÍODO DE ESTRUTURA	-		
CREMALHEIRA PCT (LOG)	2 EQUIP	1 MOBILIZAÇÃO POR EQUIP	1 DESMOBILIZAÇÃO POR EQUIP	-	TODO PERÍODO	TODO PERÍODO		
MINIGRUA (LOG)	2 EQUIP	1 MOB POR MINIGRUA POR TORRE (TART 2X2)	1 DESMOB POR MINIGRUA POR TORRE (TART 2X2)	-	TODO PERÍODO	-		

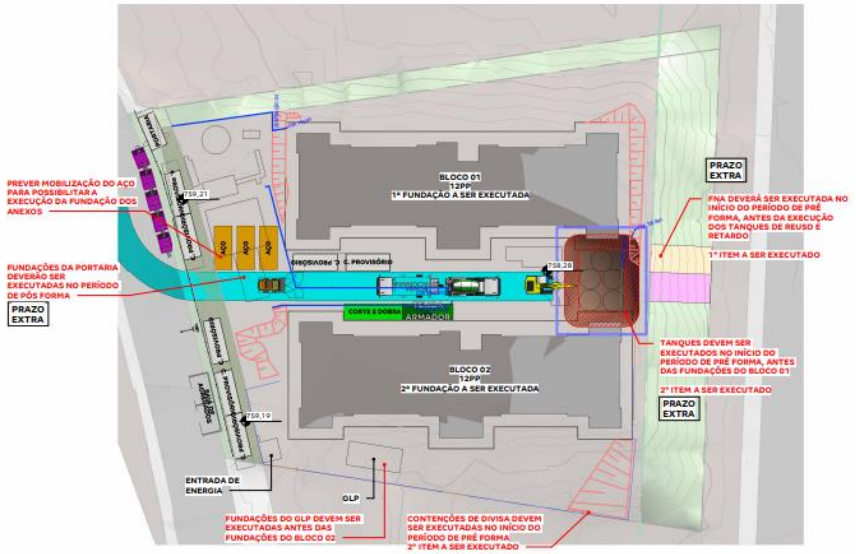

PRÉ FORMA
1 : 500

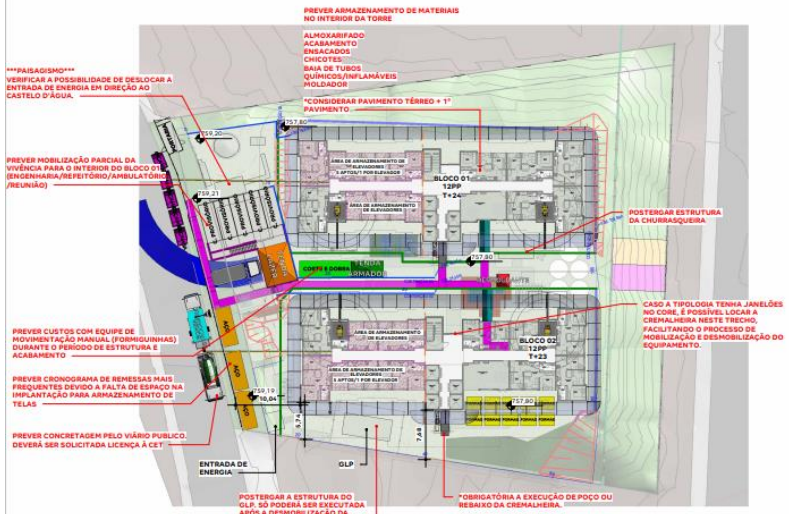

ESTRUTURA E ACABAMENTO
1 : 500

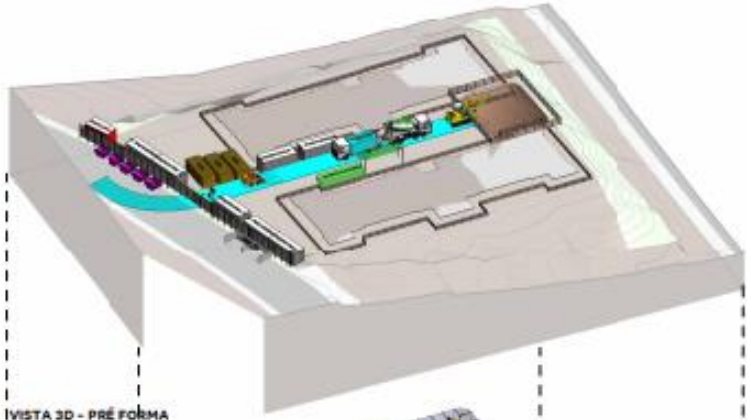

VISTA 3D - PRÉ FORMA

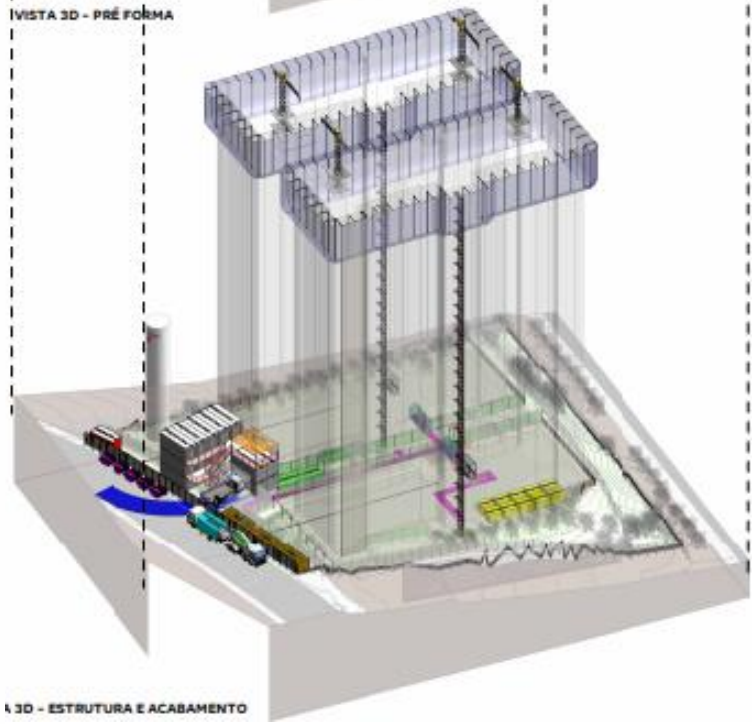

3D - ESTRUTURA E ACABAMENTO

PCP 167

Empreendimento	Lançto.	Unidades	# jogos	Equipes de forma	Início Obra	Início Forma 1	Início Forma 2	Início Forma 3	Término Forma 1	Término Forma 2	Término Forma 3	Previsão AGI	Folga Inicio	Folga Aptidão	Folga Cliente	Carência CEF
CDW 10 | Oásis Penha	jul/25	672	2	B	28/12/25	11/06/26	27/06/26		14/01/27	30/01/27		out/27	5,53	5,53	9,13	NC
CDW 15 | Jd dos Prados	jul/25	796	2	D	02/02/26	17/06/26	21/06/26		02/03/27	06/03/27		dez/27	6,77	6,77	7,10	NC
CDW 15 | Sobral	set/25	577	2	F	21/12/25	19/07/26	14/08/26		22/01/27	17/02/27		nov/27	3,26	3,26	10,17	NC
CDW 10 | Adriático	out/25	642	2	B	25/06/26	15/01/27	31/01/27		11/08/27	27/08/27		mai/28	8,45	8,45	5,10	NC
CDW 15 | Dália	out/25	667	3	F	06/06/26	23/01/27	18/02/27	05/03/27	17/06/27	13/07/27	10/08/27	set/28	8,29	8,29	1,03	NC
CDW 15 | Horizonte Jaraguá	dez/25	514	2	D	21/02/26	03/03/27	07/03/27		16/08/27	20/08/27		mai/28	2,28	2,28	7,13	NC
CDW 15 | Vila Butantã	jan/26	808	3	F	26/07/26	18/06/27	14/07/27	11/08/27	09/12/27	04/01/28	01/02/28	out/28	6,40	6,40	3,07	NC
CDW 10 | Cunha	jun/26	357	2	B	14/01/27	12/08/27	28/08/27		06/12/27	22/12/27		ago/28	7,11	7,11	10,10	NC
CDW 10 | Essência do Campo F1	jul/26	550	2	D	18/02/27	17/08/27	21/08/27		11/02/28	15/02/28		out/28	7,29	7,29	9,10	NC
CDW 15 | Essence Butantã (Eiras Garcia)	ago/26	357	2	B	10/07/27	07/12/27	23/12/27		31/03/28	16/04/28		dez/28	10,97	10,97	8,10	NC
CDW 15 | Florença	nov/26	521	3	F	13/07/27	10/12/27	05/01/28	02/02/28	01/04/28	27/04/28	24/05/28	jan/29	8,03	8,03	10,10	NC
CDW 15 | Amarilis	dez/26	512	2	D	01/08/27	12/02/28	16/02/28		27/07/28	31/07/28		mar/29	7,66	7,66	9,17	NC
CDW 10 | Monte Trindade	mar/27	751	2	B	03/11/27	01/04/28	17/04/28		01/12/28	17/12/28		ago/29	7,80	7,80	7,07	NC
CDW 10 | Essência do Campo F2	dez/27	354	3	F	23/10/27	02/04/28	28/04/28	25/05/28	17/06/28	13/07/28	09/08/28	abr/29	-1,75	-1,75	20,33	NC

Pareceres

Análise da Mancha e Implantação

Prospecção

Operações

Inteligência de Mercado

Financeiro

Demanda e Distribuição da Mancha

Potencial de Demanda			Lançados		Lançados + Landbank	
Mancha	CÓD.	Shr.	ANO	MÊS	ANO	MÊS
São Paulo Leste	SZL	35%	3.143	262	3.771	314

Empreendimento	Renda	Lançamento	set/25	out/25	nov/25	dez/25	jan/26	fev/26	mar/26	abr/26	mai/26	jun/26	jul/26	ago/26	set/26	out/26	nov/26	dez/26	jan/27	fev/27	mar/27	abr/27	mai/27	jun/27
Viva São Miguel	3.980	jun-24	26	24																				
Reserva Das Andorinhas	4.000	set-24	10	10	10	10	10	10	10	10	10	10	10	10	10	10	10	10	10	10	10	10	10	10
Viva Parque Do Carmo	4.550	set-24	32	32	32	32	32	32	32	22														
Palermo	3.038	dez-24	8	8	8	8	8	8	8	8	8	8	8	8	8	8	8	8	8	8	8	8	8	8
Oásis Penha	5.177	jul-25	37	37	37	37	37	37	37	37	37	37	37	37	37	37	37	34						
Tucuma	3.409	set-25	15	30	30	30	30	30	30	30	30	30	30	30	30	30	30	30	30	30	5			
Alvorada Aricanduva	**3.658**	**set-25**		**32**	**32**	**32**	**32**	**32**	**32**	**32**	**32**	**32**	**32**	**32**	**32**	**32**	**32**	**32**	**32**	**32**	**32**	**1**		
Residencial Quioto	2.938	fev-26							38	38	38	38	38	38	38	38	38	38	38	38	38	38	38	38
Amarilis	3.034	ago-26													54	54	54	54	54	54	54	54	54	54
Etelvina (Aurora)	3.874	fev-27																			21	21	21	21
Jerivas	3.530	abr-27																					50	50
Total de Vendas Lançados			**113**	**111**	**87**	**87**	**87**	**87**	**87**	**77**	**55**	**55**	**55**	**55**	**55**	**55**	**55**	**52**	**18**	**18**	**18**	**18**	**18**	**18**
Total de Vendas Lançados + Landbank			**128**	**173**	**149**	**149**	**149**	**149**	**187**	**177**	**155**	**155**	**155**	**155**	**209**	**209**	**209**	**206**	**172**	**172**	**168**	**132**	**181**	**181**

Devido a proximidade de distância e preço, Alvorada Aricanduva possuí risco de canibalização com o Viva Parque do Carmo. Esse risco foi mitigado pelo time de ciclo, que em BP diferenciou o preço e volume dos dois projetos.

Parecer de I.M sobre a mancha:

O projeto analisado em comitê está em linha com o potencial teórico de demanda calculado para a mancha. (Total Lançados)

Canibalização:

Risco de Canibalização

Alvorada Aricanduva | Mapa Concorrência

		Alvorada Aricanduva	Condomínios Nascente Parque Sapopemba	Gran Arena Itaquera	Meu Plano&Parque Do Carmo
		TENDA	Direcional	MRV	Plano & Plano
	Distância Tenda (km)		3,55Km	4,72Km	5km
Região 1 Km	População	31.681	51.555	27.521	11.348
	Dens. Demográfica	10.132	16.516	8.817	3.635
	Renda (R$)	5.650	4.750	5.692	4.265
	Classe Social	B2 (4.6k a 8.1k)	C1 (2.7k a 4.6k)	B2 (4.6k a 8.1k)	C1 (2.7k a 4.6k)
	PEA Dia	17.265	26.112	15.003	11.037
Quantitativo	Lançamento	set/25	08/2023	12/2024	set/24
	Unidades	577	230	624	2.463
	Estoque	577	19	278	842
	VSO	32	23	43	33
	Stockout	18	1	6	26
Qualitativo	Condomínios	1	1	1	1
	Torres	-	9	5	7
	Gabarito	-	T+9	T+17	T+9
	Plantas (m²)	32m²	43,6m² e 32,2m² e 32,2m²	35m² e 34,23m²	32,18m² e 32,1m² e 32,19m²
	Tipologia	2 Dorms	2 Dorms	2 Dorms	2 Dorms
	Opções	Não	Garden	Não	Não
	Varanda	Não	Não	Não	Não
	Vagas	Sem vaga	Sem vaga	Com vaga	Sem vaga
	Lazer	Praça de chegada, bicicletários, espaço office, Play baby, Play kids, Mini Market/delivery, Brinquedoteca, Multipla Estação, Play pet.	Garden, quadra de Futebol, cinema, fireplace, fitness center, lago, piscina, piso elevado, praça, salão de jogos, sauna seca	Bosque, Cinema, Praça, Quiosque, Salão de Jogos,	Bosque, quadra de futebol, cinema, decorado, espaço gourmet, lago, pet place, piso elevado, praça, quadra de tênis, salão de jogos, sauna seca

Diagnóstico Concorrência

- Embora o preço e a renda da Plano Plano sejam competitivos, o Viva Parque do Carmo, projeto referência da região, já alcança o preço e a renda estimado no parecer.
- Os demais concorrentes atraí clientes de rendas altas.

Farol Renda
Acima de 300
Entre 0 e 300
Abaixo de 0

-	Alvorada Aricanduva				Condomínios Nascente Parque Sapopemba					Gran Arena Itaquera					Meu Plano&Parque Do Carmo				
Tipologias	Preço Nominal	CEF	Renda	% Unidades	Preço Nominal	CEF	Renda	% Unidades	Farol	Preço Nominal	CEF	Renda	% Unidades	Farol	Preço Nominal	CEF	Renda	% Unidades	Farol
HIS | HMP	234.664	189.344	3.658	100%	245.000	196.000	4.000	-	●	275.031	220.025	4.240	69%	●	222.464	177.971	3.650	100%	●
Vg Carro	-	-	-	-	-	-	-	-	-	343.898	275.118	6.700	31%	-	-	-	-	-	-
Garden	-	-	-	-	289.457	231.566	5.600	-	-	-	-	-	-	-	-	-	-	-	-

Simulação de Preço – Cenário Aprovação

Informações Viabilidade

Projeto:	Alvorada Aricanduva			
Tipo:	**HMP**		**HIS | HMP**	
Método	**Ref - Viva Pq. Do Carmo**		**Vision**	
Avaliação	248.000		248.000	
Renda Inicial (VF)	4.040		3.648	
Renda Final*	-		-	
% RET1	0%		25%	
Tipo:	**VF**	**R$**	**VF**	**R$**
Ato	0,34	1.305	0,66	2.417
FGTS	0,44	1.679	0,64	2.326
Financiamento	98,66%	175.842	97,62%	183.429
Subsídio	90,60%	1.864	149,83%	3.588
Prazo de Pró-soluto	28	28	28	28
Pró-Soluto	77,48%	31.845	78,77%	29.232
Preço Raso (RS)	212.535	212.535	220.993	220.993
TCD	25,17%	10.251	39,41%	14.492
VSO	32	32	32	32
Preço de Venda	**233.691**	**233.691**	**235.485**	**235.485**
Elasticidade	-4,667%	-4,667%	0,000%	0,000%
Preço de Venda Final	**222.785**	**222.785**	**235.485**	**235.485**
Preço Raso (R$)	**212.535**		**220.993**	
% de Raso	**95,40%**		**93,85%**	
BP25 - Não Inflacionado	**-**		**214.269**	
BP25 - Inflacionado	**-**		**224.002**	

Simulação de Preço

Informações Viabilidade

Projeto:	Alvorada Aricanduva			
Tipo:	**HMP**		**HIS | HMP**	
Método	**Ref - Viva Pq. Do Carmo**		**Vision**	
Avaliação	248.000		248.000	
Renda Inicial (VF)	4.040		3.658	
Renda Final*	-		-	
% RET1	0%		25%	
Tipo:	**VF**	**R$**	**VF**	**R$**
Ato	0,34	1.305	0,66	2.417
FGTS	0,44	1.679	0,64	2.326
Financiamento	100,20%	175.842	97,84%	183.429
Subsídio	90,60%	1.864	151,33%	3.588
Prazo de Pró-soluto	25	25	25	25
Pró-Soluto	77,48%	28.433	78,55%	26.100
Preço Raso (RS)	209.123	209.123	217.861	217.861
TCD	25,17%	10.251	45,57%	16.803
VSO	32	32	32	32
Preço de Venda	**230.112**	**230.112**	**234.664**	**234.664**
Elasticidade	-4,667%	-4,667%	0,000%	0,000%
Preço de Venda Final	**219.373**	**219.373**	**234.664**	**234.664**
Preço Raso (R$)	**209.123**		**217.861**	
% de Raso	**95,33%**		**92,84%**	
BP25 - Não Inflacionado	**-**		**210.963**	
BP25 - Inflacionado	**-**		**220.696**	

Análise de Preço

Informações Viabilidade

Projeto:	Alvorada Aricanduva
Tipo:	**Faixa 2**
Método	**Vision**
Avaliação	248.000
Renda Inicial (VF)	3.658
Renda Final*	-

Tipo:	VF	R$
Ato	0,66	2.417
FGTS	0,64	2.326
Financiamento	97,84%	183.429
Subsídio	151,33%	3.588
Prazo de Pró-soluto	25	25
Pró-Soluto	78,55%	26.100
Preço Raso (RS)	217.861	217.861
TCD	45,57%	16.803
VSO	32	32
Preço de Venda	**234.664**	**234.664**
Elasticidade	0,000%	0,000%
Preço de Venda Final	**234.664**	**234.664**
Preço Raso (R$)	**217.861**	
% de Raso	**92,84%**	
Raso Todas as Fases	**217.861**	
Nominal Todas as Fases	**234.664**	

1

Análise de Riscos	Farol IM
IM avalia o Preço Vision como **factível**.	

1) I.M está de acordo com o preço Vision, tendo em vista que, o projeto está em uma região com bons indicadores sociodemográficos, como renda e PEA/Dia, o mesmo também se encontra próximo de pontos de interesses como hospital, escola e etc.

Conforme consta no slide "Panorama de Concorrência", embora o preço e a renda da Plano Plano sejam competitivos, o Viva Parque do Carmo, projeto referência da região, já alcança o preço e a renda estimado no parecer.

	Preço Real					Preço Normalizado (25m)	
	Avaliação	Preço Raso	Renda Média	VSO	PSOL	Δ PSOL	Preço Raso
Palermo	234.548	206.687	3.038	8	27	-1.988	204.699
Tucumã *Comitê*	241.000	215.015	3.409	30	28	-3.399	211.616
Viva São Miguel	238.648	204.534	3.980	26	12	11.713	216.247
Alvorada Aricanduva	**248.000**	**217.861**	**3.658**	**32**	**25**	**-**	**217.861**
Reserva das Andorinhas	231.613	216.012	4.000	10	23	2.290	218.302
Viva Parque do Carmo - HMP	**234.968**	**219.350**	**4.040**	**25**	**25**	**0**	**219.350**
Viver Mais	251.095	221.817	4.000	72	27	-1.916	219.901
Óasis Penha	286.860	264.956	5.250	40	36	-13.870	251.086

Ciclo Financeiro – Análise Mancha

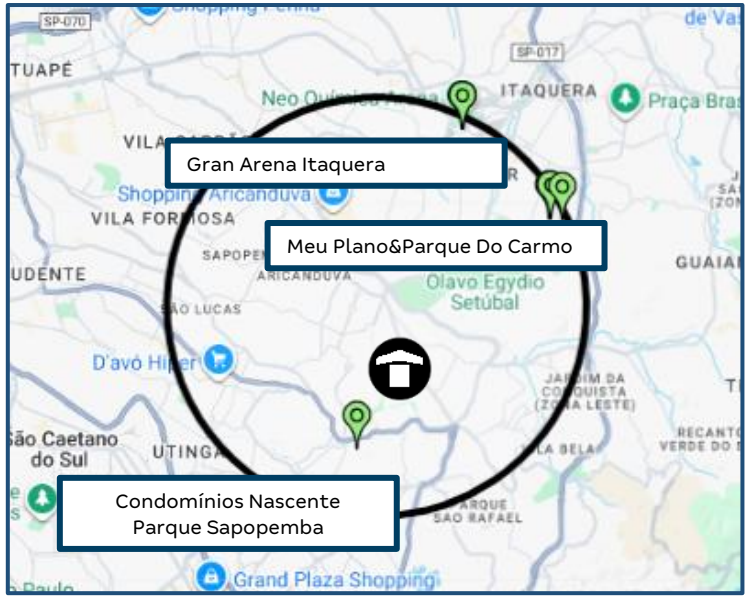

	Preço Real					Preço Normalizado (25m)	
	Avaliação	Preço Raso	Renda Média	VSO	PSOL	Δ PSOL	Preço Raso
Palermo	234.548	206.687	3.038	8	27	-1.988	204.699
Tucumã *Comitê*	241.000	215.015	3.409	30	28	-3.399	211.616
Viva São Miguel	238.648	204.534	3.980	26	12	11.713	216.247
Alvorada Aricanduva	**248.000**	**217.861**	**3.658**	**32**	**25**	**-**	**217.861**
Reserva das Andorinhas	231.613	216.012	4.000	10	23	2.290	218.302
Viva Parque do Carmo - HMP	**234.968**	**219.350**	**4.040**	**25**	**25**	**0**	**219.350**
Viver Mais	251.095	221.817	4.000	72	27	-1.916	219.901
Óasis Penha	286.860	264.956	5.250	40	36	-13.870	251.086

Parecer Ciclo

O Ciclo validou o preço e o VSO como viáveis. O projeto está estrategicamente localizado na região da Aricanduva, já consolidada pela Tenda com os lançamentos Ouro Preto e Tiradentes. A área apresenta forte potencial de demanda e, mesmo diante da presença da Plano, temos um case de sucesso recente na mancha, Viva Parque do Carmo, que comprova a atratividade do mercado, com excelentes resultados em preço e volume consistente.

- Pareceres
- Análise da Mancha e Implantação
- Prospecção
- Operações
- Inteligência de Mercado
- Financeiro

Informações Financeiras – Resumo

Alvorada Aricanduva – SP – São Paulo Capital

Datas e Prazos

	Compra	Lançamento	Início Obra	Término Obra	LÇTO até IO	IO até TO	Chaves	LÇTO até Chaves
Fase única	mai-24	set-25	mar-26	fev-28	6 meses	23 meses	set-28	36 meses

Terreno e Incorridos

TOTAL (R$ + Perm.):	11,70 MM	Incorrido Terreno:	0,45 MM	Área do Terreno (100%):	4.257 m²
Cash:	0,45 MM	Nº de Parcelas Cash :	10	Custo de terreno m²:	2.748,2
Permuta Financeira:	11,25 MM (12,30%)			VaR 25 (R$ mil):	0
Permuta Física:	0,00 MM (0,00%)			VaR 26 (R$ mil):	0
Ato / %VGV:	0,05 MM / 0,0%			Incorrido de Construção:	0,06 MM

Área Líquida do Terreno:	3.243 m²
Custo de terreno m² Área Líquida:	3.607,8
Fração Terreno/Terreno + Custo Obra (%VGV):	8,6% / 53,2%
CA Máx/Proj.	7,2 / 4,5
Incorridos de Incorporação:	0,03 MM

Vendas

Fases	Nº Pavimentos	Preço Raso Unit.	Qtde	Preço Unit.	Aval. CEF	Cond. Parcela	% Pró-soluto	% TCD
Fase Única	T+24	220.993	577	235.485	248.000	97,6%	78,8%	39,4%

Unidades Totais:	577	Preço Médio:	235.485	Renda Média:	3.648	ITBI+Emol. Unit. Médio:	2.757
Unidades Tenda:	577	Avaliação Média:	248.000	Ato:	2.417 (0,66 Salários)	Custo do Ciclo Unit.:	14.823
VSO:	32 Unidades	VGV Total:	135.874.753	FGTS:	2.326 (0,64 Salários)	Preço Raso Médio:	220.993
RET Médio:	3,3%	VGV Tenda:	135.874.753	% em RET 1%:	25%	Adc. Tx. de Aceleração Médio:	750

Construção

Custo Total Unit.:	105.049	Eventuais:	4,00%	Área priv (m²):	32,03

Gape / Mês Unit.:	11,08

Resultado

LI (R$):	19.242.178	LI:	19,99%	Exposição de Caixa (R$):	9.929.133
TIR:	143,66%	LI Aprovação:	20,00%	Ger. Caixa 12 meses (R$):	(8.462.839)
Exposição de Caixa:	7,40%	Δ LI:	-0,01%	Ger. Caixa 24 meses (R$):	14.142.517
Payback Contingente (21 m):	19 m/ (-2 m)	LI Marginal:	20,60%	Ger. Caixa Marginal (R$):	32.630.824
Payback Consolidado:	19 meses				

Margem Bruta Econômica:	36,53%
Margem Bruta REF:	40,10%
Margem Rasa Econômica:	31,80%
Margem Rasa REF:	36,18%
Margem de Contribuição Econômica:	25,82%

DRE

R$ Mil - Valores Nominais - Compra	Alvorada Aricanduva	
	Nominal	%
Receita	134.268	100,0%
PIS/COFINS	(2.393)	1,8%
Custo Total	(83.703)	63,5%
Custo Terreno	(10.801)	8,2%
Custo Relacionados a Terreno	(1.135)	0,9%
Custos de Incorporação	(2.710)	2,1%
Custo de Construção	(69.057)	52,4%
Lucro Bruto Econômico	48.172	36,5%
Custo para Rateio	-	0,0%
Lucro Bruto Contábil	48.172	36,5%
Despesas de Selling	(11.034)	8,4%
Contingência	(3.088)	2,3%
Margem de Contribuição	34.050	25,8%
IR e CSLL	(1.958)	1,5%
Margem Líquida	32.092	24,3%
Lucro Bruto REF Unit.	96.354	40,1%
Lucro Raso REF Unit.	81.586	36,2%

R$ Mil - VPL - Compra	Alvorada Aricanduva	
	VP	%
Receitas	96.250	100,0%
PIS/COFINS	(1.690)	1,8%
Custos e Despesas Totais	(75.318)	78,3%
Custo Terreno	(7.998)	8,3%
Custo Relacionados a Terreno	(1.064)	1,1%
Custos de Incorporação	(2.314)	2,4%
Custo de Construção	(51.978)	54,0%
Despesas de Selling	(9.456)	9,8%
Contingência	(1.126)	1,2%
IR e CSLL	(1.382)	1,4%
Lucro Imobiliário	19.242	20,0%

Comparativo BP

Comparativo dos Estudos - Consolidado	BP - 2025	Atual	Atual vs BP - 2025	Δ%
Data Estudo:	setembro-24	agosto-25	11 Meses	N/A
Lançamento:	setembro-25	setembro-25	0 Meses	N/A
Uhs:	577	577	-	0,0%
Preço Nominal:	227.894	235.485	7.591	3,3%
Preço Raso:	216.796	220.993	4.196	1,9%
Preço Nominal Inflacionado:	248.807	240.275	(8.532)	-3,4%
Preço Raso Inflacionado:	236.716	225.507	(11.209)	-4,7%
Renda Média:	4.258	3.648	(610)	-14,3%
RET Médio:	3,25%	3,25%	0,0 p.p.	0,0%
% em RET 1%:	25,00%	25,00%	0,0 p.p.	0,0%
VSO:	32	32	-	0,0%
ITBI/Emol. Inf (Unit)[2]:	5.436	3.527	(1.909)	-35,1%
Avaliação:	250.000	248.000	(2.000)	-0,8%
Prazo construção F1:	22	23	1	4,5%
Prazo de Pró-Soluto F1:	27	28	1	3,7%
Custo Total Inf (Unit):	154.532	145.066	(9.466)	-6,1%
Custo Construção (Unit):	101.253	105.049	3.796	3,7%
Fração de construção:	43,9%	44,6%	0,7 p.p.	1,7%
INCC Folha Rosto:	1.168,21	1.199,51	31	2,7%
Custo Terreno Inf:	17.537.300	10.800.608	(6.736.691)	-38,4%
Custo Relacionados a Terreno (Unit):	2.304	1.967	(337)	-14,6%
Fração do Terreno[1]:	12,7% / 57,1%	8,6% / 53,2%	-4,1 p.p.	-32,3%
ITBI/Emol. Inf (Total)[2]:	3.136.374	2.034.919	(1.101.454)	-35,1%
Custo do Ciclo (Unit):	14.346	14.823	478	3,3%
Lucro Imobiliário:	17,7%	20,0%	2,3 p.p.	13,1%
LI Marginal:	17,7%	20,6%	2,9 p.p.	16,6%
Exposição de caixa:	9,4%	7,4%	-2,0 p.p.	-21,2%
TIR:	139,5%	143,7%	4,1 p.p.	3,0%
Margem Bruta REF:	38,5%	40,1%	1,6 p.p.	4,2%
Margem Bruta Econômica:	34,3%	36,5%	2,2 p.p.	6,5%
Margem Rasa REF:	35,3%	36,2%	0,9 p.p.	2,4%
Margem Rasa Econômica:	30,5%	31,8%	1,3 p.p.	4,3%
Margem Contribuição Econômica:	22,6%	25,8%	3,2 p.p.	14,1%
Payback Contingente (Régua 21 m):	19 m/ (-2 m)	19 m/ (-2 m)	0	0,0%
Payback Consolidado:	19 Meses	19 Meses	0 Meses	0,0%

[1] Valor do terreno contratual

[2] ITBI com taxa de Aceleração

Resumo

Alvorada Aricanduva – SP – São Paulo Capital

Datas e Prazos

	Compra	Lançamento	Início Obra	Término Obra	LÇTO até IO	IO até TO	Chaves	LÇTO até Chaves
Fase única	mai-24	set-25	dez-25	nov-27	3 meses	23 meses	set-28	36 meses

Terreno e Incorridos

TOTAL (R$ + Perm.):	11,70 MM	Incorrido Terreno:	0,45 MM	Área do Terreno (100%):	4.257 m²
Cash:	0,45 MM	Nº de Parcelas Cash :	10	Custo de terreno m²:	2.748,2
Permuta Financeira:	11,25 MM (12,30%)			VaR 25 (R$ mil):	0
Permuta Física:	0,00 MM (0,00%)			VaR 26 (R$ mil):	0
Ato / %VGV:	0,05 MM / 0,0%			Incorrido de Construção:	0,06 MM

Área Líquida do Terreno:	3.243 m²
Custo de terreno m² Área Líquida:	3.607,8
Fração Terreno/Terreno + Custo Obra (%VGV):	8,6% / 53,4%
CA Máx/Proj.	7,2 / 4,5
Incorridos de Incorporação:	0,03 MM

Vendas

Fases	Nº Pavimentos	Preço Raso Unit.	Qtde	Preço Unit.	Aval. CEF	Cond. Parcela	% Pró-soluto	% TCD
Fase Única	T+24	217.861	577	234.664	248.000	97,8%	78,6%	45,6%

Unidades Totais:	577	Preço Médio:	234.664	Renda Média:	3.658	ITBI+Emol. Unit. Médio:	2.757
Unidades Tenda:	577	Avaliação Média:	248.000	Ato:	2.417 (0,66 Salários)	Custo do Ciclo Unit.:	14.772
VSO:	32 Unidades	VGV Total:	135.400.862	FGTS:	2.326 (0,64 Salários)	Preço Raso Médio:	217.861
RET Médio:	3,3%	VGV Tenda:	135.400.862	% em RET 1%:	25%	Adc. Tx. de Aceleração Médio:	750

Construção

Custo Total Unit.:	105.049	Eventuais:	4,00%	Área priv (m²):	31,84	Gape / Mês Unit.:	11,08

Resultado

LI (R$):	19.094.302	LI:	19,48%	Exposição de Caixa (R$):	13.434.183	Margem Bruta Econômica:	36,94%
TIR:	122,02%	LI Aprovação:	20,00%	Ger. Caixa 12 meses (R$):	(12.657.383)	Margem Bruta REF:	40,52%
Exposição de Caixa:	10,04%	Δ LI:	-0,52%	Ger. Caixa 24 meses (R$):	17.560.394	Margem Rasa Econômica:	31,48%
Payback Contingente (21 m):	19 m/ (-2 m)	LI Marginal:	20,08%	Ger. Caixa Marginal (R$):	33.037.949	Margem Rasa REF:	35,93%
Payback Consolidado:	19 meses					Margem de Contribuição Econômica:	26,22%

DRE

R$ Mil - Valores Nominais - Compra	Alvorada Aricanduva	
	Nominal	%
Receita	133.751	100,0%
PIS/COFINS	(2.384)	1,8%
Custo Total	(82.839)	63,1%
Custo Terreno	(10.801)	8,2%
Custo Relacionados a Terreno	(1.075)	0,8%
Custos de Incorporação	(2.741)	2,1%
Custo de Construção	(68.223)	51,9%
Lucro Bruto Econômico	48.528	36,9%
Custo para Rateio	-	0,0%
Lucro Bruto Contábil	48.528	36,9%
Despesas de Selling	(11.002)	8,4%
Contingência	(3.076)	2,3%
Margem de Contribuição	34.449	26,2%
IR e CSLL	(1.950)	1,5%
Margem Líquida	32.499	24,7%
Lucro Bruto REF Unit.	97.014	40,5%
Lucro Raso REF Unit.	79.886	35,9%

R$ Mil - VPL - Compra	Alvorada Aricanduva	
	VP	%
Receitas	98.016	100,0%
PIS/COFINS	(1.721)	1,8%
Custos e Despesas Totais	(77.201)	78,8%
Custo Terreno	(8.167)	8,3%
Custo Relacionados a Terreno	(1.020)	1,0%
Custos de Incorporação	(2.361)	2,4%
Custo de Construção	(53.637)	54,7%
Despesas de Selling	(9.437)	9,6%
Contingência	(1.171)	1,2%
IR e CSLL	(1.408)	1,4%
Lucro Imobiliário	19.094	19,5%

Análise da Mancha e Implantação

Prospecção

Operações

Inteligência de Mercado

Financeiro

Pareceres

Anexos

- **DESCRIÇÃO DO IMÓVEL:** Matrícula nº 193.362 do 9º Oficial de Registro de Imóveis de São Paulo/SP, cadastrado perante à Prefeitura de São Paulo sob nº 149.220.0006-5 ("Imóvel"), situado à Rua Estado do Ceará, nº 1.186, Vila Egle, no 27º Subdistrito do Tatuapé.

- **PROPRIETÁRIA:** PORTOINVEST ADMINISTRAÇÃO E PARTICIPAÇÃO LTDA.

- **DA CONSULTA AO CADASTRO NACIONAL DE EMPRESAS INIDÔNEAS E SUSPENSAS (CEIS):** Consultas realizadas em 24/05/2024, restaram negativas para a proprietária e suas sócias.

- **CONSIDERAÇÕES JURÍDICAS SOBRE O IMÓVEL:** Conforme o relatório dos Estudos Jurídicos emitido pelo RAA Advogados e Estudos Técnicos emitido pela Top Perícias, respectivamente datados de 04/12/2019 e 18/12/2019, bem como relatório complementar do NFA datado de 24/05/2024, foram apontadas, em suma, as seguintes considerações: **(**; **(b) Loteamento:** Em que pese não foram localizados loteamentos que englobem a área objeto de estudo, mas considerando a cadeia fili**a) Retificação:** No comparativo entre a área física e registraria do Imóvel, verificou-se que a área real é de 4.285,21m² e a área registraria de 4.257,30m², tendo uma diferença de 27,91m² entre físico e registro, sendo a área registraria menor que a real em percentual inferior a 5% (cinco por cento), tendo sido concluído que o Imóvel é tecnicamente perfeito, apresentando todas as medidas perimetrais e a área final encerrada do terreno, bem como que inexiste possibilidade de retificação de área, pois o Imóvel já foi retificado judicialmente, sem erros técnicos identificados, e a situação física é praticamente a mesma configurada no registro do Imóvel, bem como a existência de loteamentos próximos, recomenda-se a realização de estudo técnico junto à Prefeitura de São Paulo, no intuito de verificar a existência ou não de restrição construtiva nos arquivos dos entes Municipais e que não tenham sido objeto de inscrição ou registro nos Cartórios de Registro de Imóveis competentes; **(c) Regularidade Ambiental:** Na consulta preliminar consta patrimônio ambiental que ocorre pela presença de certos exemplares de fauna e flora, havendo imunidade de corte e poda dos exemplares arbóreos listado no Decreto do Município de São Paulo nº 30.443/1989. Demais certidões, ainda pendentes (prev 16/06 e 16/08). **DD DO IMÓVEL: (a) Área construída**: Certidão de Dados Cadastrais e Notificação de Lançamento de IPTU indicam terreno sem construção, a matrícula menciona "UM PRÉDIO", sem indicação da área, será necessário regularizar a demolição com certidão específica da Prefeitura a ser providenciado por LEG e Jurídico; **(b) Débitos Imobiliários**: IPTU 2024 - inscrito em dívida ativa (não ajuizado), no valor atualizado de R$ 53.734,31 (principal de R$ 48.849,38 e encargos de R$ 4.884,93); IPTUs 2023, 2022, 2021 e 2000 – PPI Homologado 21.738.674-1 – Saldo remanescente R$ 119.659,65; IPTUs 2020, 2019 e 2018 – PPI Homologado 3.165.464-9 – Saldo remanescente R$ 182.135,35; IPTUs 2017, 2016 e 2015 – PPI Homologado 3.165.464-9 – Saldo remanescente R$ 80.234,82 na data de 22/08/2025. Os valores poderão sofrer reajustes até a data do pagamento; IPTU 2020 - R$17.997,50 **(c) Ônus e Gravames**: não há; **(d) Ocupação**: não há; **(e) TAC**: não há; **(f) CONDEPHAAT e CONPRESP:** certidões negativas; **(g) IPHAN:** certidão pendente (prev 16/06); **(h) Desapropriação e Melhoramentos:** certidões pendentes (prev. 25/06 e 25/07); **(i) Função Social da Propriedade:** não há notícia de que o Imóvel tenha sido notificado em virtude de eventual descumprimento da função social da propriedade..

- **CONSIDERAÇÕES SOBRE A PROPRIETÁRIA E SÓCIO OCULTO:**

- **A) Proprietária:**
  - Passivo: Foram identificados passivo atualizado de R$ 1.795.767,86 referente a débitos mobiliários do município de São Paulo e ação judicial cível (Cumprimento de Sentença nº 033575-58.2021.8.26.0100)
  - Patrimônio devidamente registrado: R$ 1.432.022,00

- **B) Sócio Oculto da Proprietária:**
  - Alberto Carlos Lopes Fernandes

  - Passivo: Foram identificado dois processos judiciais, os quais totalizam R$ 1.810.930,62, sendo r$ 15.162,76 de uma Execução de Título Extrajudicial e R$ 1.795.767,86, correspondente ao Cumprimento de sentença indicado acima.
  - Patrimônio: Em busca não foram localizados ou fornecidos comprovantes de imóveis em nome do Sr Alberto.

  - **SOLUÇÃO JURÍDICA PARA VIABILIZAR A ESCRITURAÇÃO:**

Apesar de constar patrimônio em imóvel registrado de 1,4MM, este não é suficiente para eliminar risco junto ao credor por ser insuficiente frente ao passivo da ação de aproximadamente 1,8MM. Baseado em parecer de nosso jurídico interno e o escritório NFA, para garantir a segurança jurídica desta aquisição, assinamos em 01set25 um aditamento com os vendedores regrando a retenção integral de todos os recebíveis no valor inicial de 2,5MM, podendo a Tenda utilizar tal recurso a seu critério não apenas para o adimplemento do passivo judicial, mas também a quitação, garantia ou cobertura de quaisquer outros débitos ou contingências, que possam recair sobre o imóvel, com fato gerador anterior a data da lavratura da escritura. A retenção representa aproximadamente 25% do valor do negócio. A liberação do recurso bloqueado, ocorrerá somente após a quitação dos débitos com o credor do vendedor e com a devida extinção da ação em curso. No paralelo faremos o acompanhamento do acordo do vendedor com o credor bem como o monitoramento da ação junto ao TJSP.
Este valor pré-determinado é além do valor antecipado para quitação do IPTU no valor de 450k

Obrigado