Tenda

sua próxima conquista

Comitê de Investimentos - Essencial

Regional: SP – Zona ZS2

Projeto: Max Berg

Data Comitê: 25.09.2025

Questionamentos – Comitê Essencial 22.09.2025

Nome	Max Berg - Essencial de Investimento	Observação - Max Berg
Renan Barbosa Sanches	Aprovado	Ok
Andre Luis Menegazzo Padilha	Aprovado	ok
Alexandre Regis de Oliveira	Aprovado	ok
Fabricio Quesiti Arrivabene	Aprovado	ok
Alejandro Octavio Abiusi	Discutir em comitê	Por que o custo de uma unidade no T+4 é tão superior ao no T+18? Na prática essas unidades T+4 terão uma margem horrível.
Luiz Mauricio de Garcia Paula	Discutir em comitê	as 3 torres que não tem o limite de gabarito da envoltória não poderiam utilizar a tipologia nova de T+25, para maximizar o CA?
Rodrigo Osmo	Discutir em comitê	(1) O que quer dizer "garantia fidejussória da Tenda"?; (2) Não entendi se é permuta ou fluxo garantido, dada essa frase: " "Preço, que serão quitadas em 30 (trinta) parcelas após o início das obras previsto para o 30º mês após a assinatura do contrato"

Observações Comitê Essencial – Max Berg

Alejandro: "Por que o custo de uma unidade no T+4 é tão superior ao no T+18? Na prática, essas unidades T+4 terão uma margem horrível."

Resposta: Primeiramente vale esclarecer/reforçar que a torre T+4 foi implantada em função de uma limitação legislativa, já que o terreno confronta com vilas em uma das laterais e que impõem uma envoltória restritiva ao gabarito limitado a 15m nesta faixa específica do terreno. Com o objetivo de não diferenciar negativamente o "produto" entre as diferentes torres (T+18/T+4) e por consequência uma redução de preço no projeto como um todo, a torre T+4 tem a mesma tipologia de apto e também com elevador, obviamente levando em consideração o equipamento otimizado conforme norma para a demanda de tráfego para uma quantidade menor de pavimentos e população.

Na viabilidade consideramos o custo consolidado R$103.871/unidade, sem diferenciar o tipo de torre. No caso dos simuladores de T+18 e T+4 os únicos valores que devem ser considerados individualmente são os custos de torre, e todos os demais são considerados na mesma base do consolidado, ou seja com rateio por unidade conforme destacado no próximo slide. Nesse cenário de abertura dos custos revisados por torre, a T+4 tem custo total de 92K/unidade, enquanto o custo total da T+18 é de R$ 106K/unidade -> equivocadamente apresentamos no book original, a abertura do custo entre torres com valores diferentes e invertidos e sem levar em consideração a premissa de rateio por unidade para todos os itens "ex" torre.

Observações Comitê Essencial – Max Berg

Alejandro: "Por que o custo de uma unidade no T+4 é tão superior ao no T+18? Na prática, essas unidades T+4 terão uma margem horrível."

CONSOLIDADO	CUSTO	R$/uh
CUSTO TOTAL I	105.013.887,00	103.769,00
INDIRETO	16.622.440,00	16.425,00
TORRE	63.969.832,00	63.211,00
INFRA	13.709.860,00	13.547,00
FUNDAÇÃO	8.596.720,00	8.495,00
ETE	-	-
EEE	-	-
CONTENÇÃO	183.646,00	181,00
TERRAPLENAGEM	1.931.388,00	1.908,00
CUSTO TOTAL II	103.252,00	102,00
VIÁRIO	-	-
DRENAGEM	-	-
EXTENSÃO ELÉTRICA	103.252,00	102,00
EXTENSÃO HIDRÁULICA	-	-
CUSTO TOTAL I + II	105.117.139,00	103.871,00
CUSTO TOTAL III	-	-
INCORRIDOS NÃO APROVEITADOS	-	-
CUSTO TOTAL I A IV	105.117.139,00	103.871,00

CUSTO T+4	CUSTO	R$/uh
CUSTO TOTAL I	105.013.886,00	92.187,00
INDIRETO	16.622.440,00	16.425,00
TORRE	63.969.832,00	51.631,00
INFRA	13.709.860,00	13.547,00
FUNDAÇÃO	8.596.720,00	8.495,00
ETE	-	-
EEE	-	-
CONTENÇÃO	183.646,00	181,00
TERRAPLENAGEM	1.931.388,00	1.908,00
CUSTO TOTAL II	103.252,00	102,00
VIÁRIO	-	-
DRENAGEM	-	-
EXTENSÃO ELÉTRICA	103.252,00	102,00
EXTENSÃO HIDRÁULICA	-	-
CUSTO TOTAL I + II	105.117.139,00	92.289,00
CUSTO TOTAL III	-	-
INCORRIDOS NÃO APROVEITADOS	-	-
CUSTO TOTAL I A IV	105.117.139,00	92.289,00

CUSTO T+18	CUSTO	R$/uh
CUSTO TOTAL I	105.013.886,00	105.737,00
INDIRETO	16.622.440,00	16.425,00
TORRE	63.969.832,00	65.181,00
INFRA	13.709.860,00	13.547,00
FUNDAÇÃO	8.596.720,00	8.495,00
ETE	-	-
EEE	-	-
CONTENÇÃO	183.646,00	181,00
TERRAPLENAGEM	1.931.388,00	1.908,00
CUSTO TOTAL II	103.252,00	102,00
VIÁRIO	-	-
DRENAGEM	-	-
EXTENSÃO ELÉTRICA	103.252,00	102,00
EXTENSÃO HIDRÁULICA	-	-
CUSTO TOTAL I + II	105.117.139,00	105.839,00
CUSTO TOTAL III	-	-
INCORRIDOS NÃO APROVEITADOS	-	-
CUSTO TOTAL I A IV	105.117.139,00	105.839,00

Nome da Fase	T+18	T+4
Lucro Imobiliário	16,4%	23,5%
Exposição de caixa	7,6%	6,8%
TIR a.a	131,7%	185,5%
Margem Bruta SJ	34,8%	41,8%
Margem Contribuição SJ	22,4%	29,4%
Cash vinculado à primeira fase?	N/A	Sim
Fase dependente:	N/A	NÃO
Número de Unidades:	468	106
Data de Escritura:	set/27	set/27
Lançamento do projeto:	nov/27	nov/27
Início da obra:	mai/28	mai/28
Curva Obra Urbanização:	Fase 1	Fase 1
Prazo de obras - GETEC:	25 meses	25 meses
Prazo de Pré-forma	5 meses	5 meses
Data de Chaves:	nov/30	nov/30
Custo Raso (R$/unid):	105.839	92.289

- **Cenários de margens com custos segregados (T+18 X T+4)**

Quando analisamos os custos de forma segregada, comparando unidades de mesma tipologia (sem varanda e sem vaga), a T+4 mantém indicadores positivos, entregando melhor resultado. Como o custo da T+18 é mais elevado, os eventuais sobem de 2% (T+4) para 4% (T+18), resultando em margens melhores para a T+4.

Dúvida 02: Luiz Mauricio

As 3 torres que não tem o limite de gabarito da envoltória não poderiam utilizar a tipologia nova de T+25, para maximizar o CA ?

Resposta: As três torres que não possuem limite de gabarito pela envoltória não podem adotar a tipologia T+25 neste momento, pois o recuo entre torres já está no limite entre elas e entre o lazer descoberto exigido – veja sombreamento em verde na imagem. Caso verticalizássemos mais, o recuo exigido aumentaria, o que resultaria em perda de unidades. De qualquer forma entendemos que existe sim oportunidade de maior adensamento com readequação principalmente do lazer piscina, mesmo que leve em consideração uma redução da lâmina da torre T+4. Este trabalho será parte do exercício do time de Negócios e Produto, com a evolução dos estudos técnicos e que serão validados no momento do comitê ampliado para atingimento da Li alvo. No momento, seguimos o cenário mais restritivo, de modo a atender aos recuos internos e respeitar o gabarito inferior à torre de maior altura existente na quadra fiscal.

Dúvida 3: Rodrigo Osmo

3.1. O que quer dizer "garantia fidejussória da Tenda"?

A expressão se refere a uma garantia prestada pela própria empresa em favor da obrigação assumida. Seria a nossa mais conhecida “Confissão de Dívida Tenda”, ou seja sem uma contratação de garantia externa (seguradora ou banco).

3.2. Não entendi se é uma permuta ou um fluxo garantido, dada essa frase: "Preço, que serão quitadas em 30 parcelas após o início das obras previstas para o 30º mês após a assinatura do contrato

Trata-se de uma Permuta Financeira de 12% sobre o VGV Bruto com valor mínimo garantido de R$31MM. O contrato determina uma “previsão” (sem obrigação) de 30 meses à partir da assinatura da PVC para o início das obras e por consequência o início da distribuição da permuta, inclusive de recebíveis acumulados. Além disto, regra que a partir do início das obras temos um limite de 30 meses (“parcelas”) ou 30 dias após o habite-se, para quitação do mínimo garantido, valendo o que ocorrer primeiro - nossa viabilidade está contemplando um pagto de permuta de 31,8MM.

One Page – Max Berg

[1]

Cidade	São Paulo	Mancha de demanda	SP - SZS2 - São Paulo Sul 2
Regional	SP	Cluster MPR	3 - Verde
Cenário de Aprovação	Aprovação	Tipo de Aprovação	Consolidado
Fase Anterior	N/A		
Tipo de Comitê	Investimento	Versão da VF	Versão 1.0: Set

[2]

Unidades (Fases)	1006 (1)	CA Máx | Proj	5,4 | 3,4
Unidades com Vaga (%)	36 (4%)	Escritura | Lançamento	set/27 | nov/27
Unidades com Varandas (%)	432 (42,9%)	Tipologia	F2E - Concreto

[3]

Valor Líquido do Terreno (% VGV)	31.755 (12,0%)	Un. Perm. Fís (% Ter)	0 (0,0%)
Cash (Correção)	0 (NA)	%VGV Perm Fin Líquida (% Ter)	12,0% (100,0%)
Valor R$/m²	3.531	VAR (%VGV)	000 (0,0%)

Custo Construção (%VGV)	104.494 (39,5%)	Indireto Unit.	16.425
Prazo da Obra (meses)	25	Torre Unit.	63.211
Custo Total Unit. | Corrigido (LPU):	103.871 | 103.339 (94)	Infra Unit.	13.547
Início de Obra	mai-28	Fundação Unit.	8.495

Preço Nominal Unit.	263.043	VSO	56
Preço Raso Unit.	241.767	Referência	VISION
Avaliação Unit.	298.961	Renda (% em RET 1%)	4.442 (14,3%)

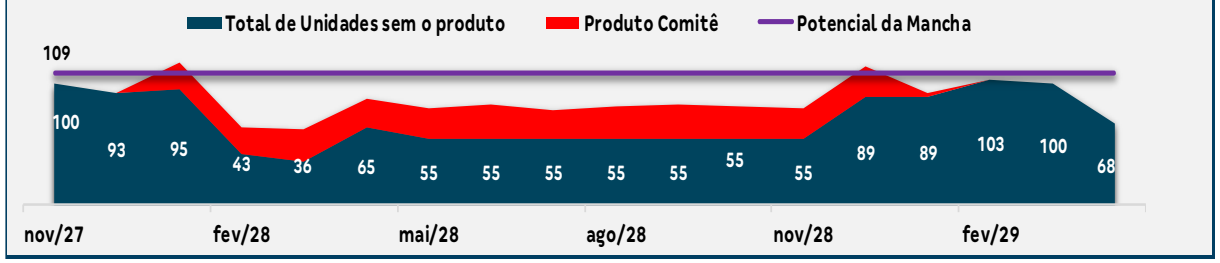

[4]

LI (Régua):	19,6% (20,0%)	Margem Bruta Econômica:	38,0%
LI Resiliência:	7,8% (N/A)	Margem Rasa Econômica:	31,8%
Margem Bruta REF:	41,4%	Margem Contribuição Econômica:	25,5%
Margem Rasa REF:	36,2%	Exposição (% VGV):	20.482 (7,0%)
TIR:	160,8%	VGV Total:	264.621
Payback Contingente (21 m) :	19 m/ (-2 m)	Ger. Caixa 12 meses (R$):	-
Payback Consolidado:	19	Ger. Caixa 24 meses (R$):	(417)

Destaques

[1] Localização: O terreno está situado na Rua Max Berg, 240 - Sacomã, mancha ZS2 – Zona Sul de São Paulo, posicionado no Cluster 3, a apenas 30 metros da Av. Padre Arlindo Vieira, importante eixo com grande oferta de comércios e serviços. Encontra-se a 4,2 km (19 min) da Estação Sacomã (Linha Verde) e a 5,4 km da Estação São Judas (Linha Azul). A futura Linha Rosa do Metrô atenderá a região com duas estações próximas: Cursino e Arlindo Vieira. Destaca-se, ainda, que o entorno conta com empreendimentos de padrão superior (conforme demonstrado no slide 12).

[2] Projeto: O projeto é composto por um condomínio único com 1.006 unidades, além de 13 vagas de automóveis e 23 vagas de motocicletas, em fase única de desenvolvimento. Entre os diferenciais: 43% das unidades contam com varanda, e o lazer dispõe de piscina e quadra esportiva como principais atributos. O terreno está inserido em zoneamento ZM (Zona Mista) sem exigência de HIS1, com quebra de gabarito pelo princípio da quadra fiscal. O projeto prevê 3 torres T+18 e 1 torre T+4, em razão da envoltória de algumas vilas confrontantes à área. O Coeficiente de Aproveitamento (CA) máximo é de 5,4, o projeto atinge CA 3,36, resultando em uma eficiência de 62%, já considerando a não ocupação da FNA localizada nos fundos do terreno.

[3] Condição Comercial: 100% Permuta Financeira
Valor total: R$ 31MM Mínimo Garantido ou 12% liquido sobre o VGV Bruto (o que for maior) -> Representa R$ 3,26 k/m² e aproximadamente R$971/CA atingido.

a) Intermediação: R$ 1,24MM que representa 4% do valor do negócio.
b) Garantia Fidejussória da Tenda.

[4] Comitê no formato Essencial; como estamos abaixo da régua, será considerado 50% do total de unidades para efeito de apuração; temos expectativa de atingirmos a régua de 20% no comitê ampliado com a evolução dos estudos.

Pareceres

Análise da Mancha e Implantação

Prospecção

Operações

Incorporação

Inteligência de Mercado

Financeiro

Anexos

Pareceres

Área	Riscos Associados	Parecer	Criticidade
Jurídico	A partir de análise prévia, verificamos que ao menos parte das empresas proprietárias, inclusive a própria APM, integra o Grupo Ruas, composto por aproximadamente 50 empresas, entre as quais se destacam a Caio Induscar e outras atuantes no setor de transporte coletivo, como a Viação Campo Belo, esta última sócia da APM.Diante desse cenário, entendemos que, na fase de due diligence, será necessário estender a auditoria às demais empresas do Grupo Ruas e/ou a seus respectivos sócios, considerando tanto a quantidade de sociedades envolvidas quanto os apontamentos identificados. Ainda no âmbito da due diligence, deverá ser verificado se os ativos dos coproprietários são suficientes para a cobertura de eventuais passivos.	Ok com ressalvas	
Legalização	Sem comentários	Ok	
Produto	Sem comentários	Ok	
Inteligência de mercado	IM avalia o Preço Vision como factível.	Ok	
Comercial/Ciclo	O Ciclo validou o preço e o VSO como viáveis. O projeto está estrategicamente localizado na região da Zona Sul. A área apresenta forte potencial de demanda e, mesmo diante da presença de concorrentes, estamos com preços competitivos.	Ok	
Estudos Econômicos	Comitê essencial de investimento, abaixo da regua de LI	Ok	

Pareceres

Análise da Mancha e Implantação

Prospecção

Operações

Incorporação

Inteligência de Mercado

Financeiro

Anexos

Prospecção | Localização – Rua Max Berg, 240 – Sacomã – São Paulo/SP

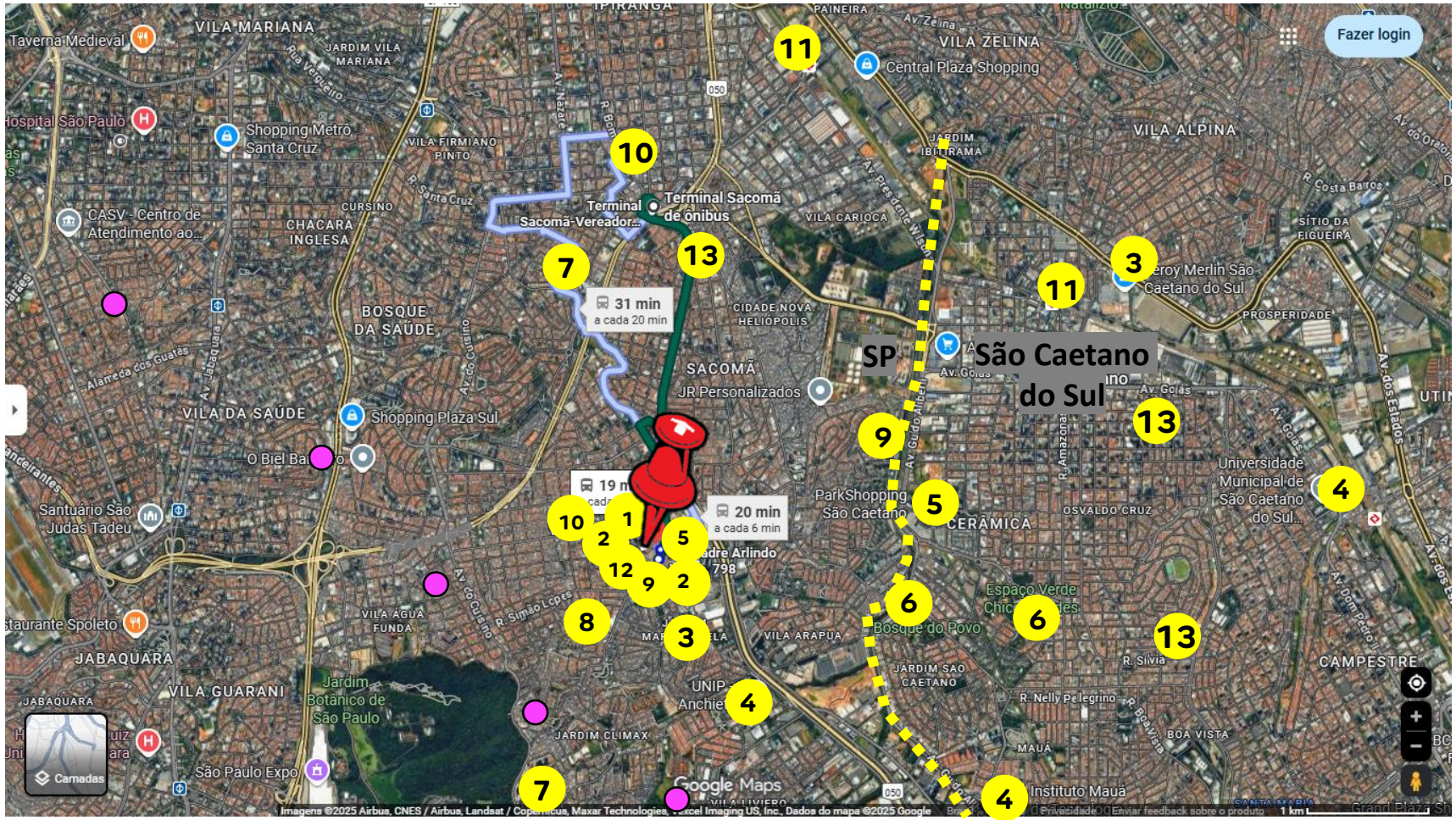

1. Estação de Bombeiros do Sacomã
2. Supermercado Extra (12 min a pé)
   Hipermercado Carrefour (11 min a pé)
3. Home center Leroy e Sodimac
4. Unip Anchieta
   Universidade Mun. São Caetano do Sul
   Instituto Mauá
5. Shopping via 80 (4 min a pé)
   Park Shopping São Caetano
6. Jardim Botânico
   Parque Municipal Bosque do Povo e Chico Mendes
7. Escola Técnica - Fatec
8. Correios
9. CEU Meninos | Colégio Mercedário (7 min a pé)
   E.E. Raul Cardoso de Almeida (10 min)
10. Metrô Sacomã / Terminal de ônibus (19 min)
11. Trem – Estações Ipiranga e São Caetano do Sul
12. UBS Vila das Mercês (8 min a pé)
    Ama/UBS Sacomã
13. Hospital Beneficência Portuguesa
    Hospital Santa Ana

Projeto de Metrô – Linha Rosa

Prospecção | Acesso – Rua Max Berg, 240 – Sacomã

FONTE: GOOGLE EARTH PRO

Mancha de Demanda

MANCHAS DE DEMANDA
- SZS – São Paulo Sul

Lançamento
1. V. Vila das Belezas

LandBank
2. Americanópolis
3. Essência do Campo
4. Dália
5. Moove Santo Amaro
6. Max Berg

Cluster MPR – (Comitê)

Cluster 5 - Roxo

Região

Capital

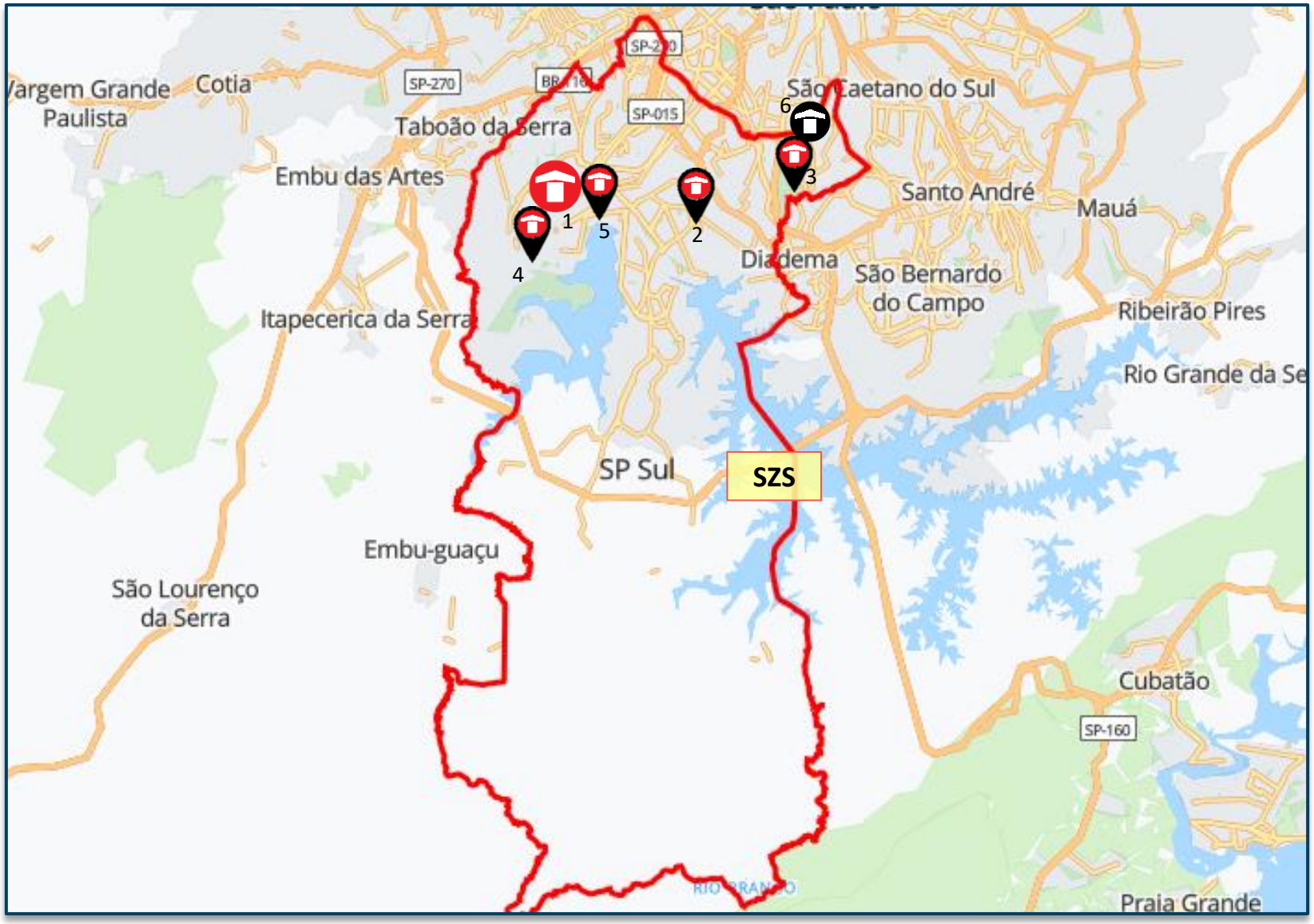

Lançados *LandBank* *Comitê*

PRODUTO

Projeto Max Berg – Comitê Essencial

Informações Gerais – Condomínio Único			
Terreno	Área terreno	9.501,29m²	
	Menor poligonal	9.501,29m²	
	FNA	Sim | 508,63m²	
	Área liquida	8.992,66m²	
	Zoneamento	ZM	
	CA máximo	5,40	ZONA: 3,00
			INCENTIVO HIS: 1,50
			COTA: 0,90
	CA projetado	3,36	
	Gabarito máximo	T+9*	
Geral	Total UH	1.006	
	Total de vagas	37 (1x PCD, 13x carros, 23x motos)	
Tipologia	Tipologia	V0200	
	Gabarito	T+04 + T+18	
	Lâmina	2LN-20PP 01x 20PP-LN-L	
	Área privativa	31,84m² | 33,59m²	
Condomínio	Unidade PCD	31	
	Unidade lazer | técnica	12 | 04	
	Torre	04	
	Fase	Única	
Lazer	Lazer coberto	1x Salão de Festas | 2x Churrasqueira	
	Lazer descoberto projetado	Quadra, piscina, play kids, play baby, pet place, fitness	

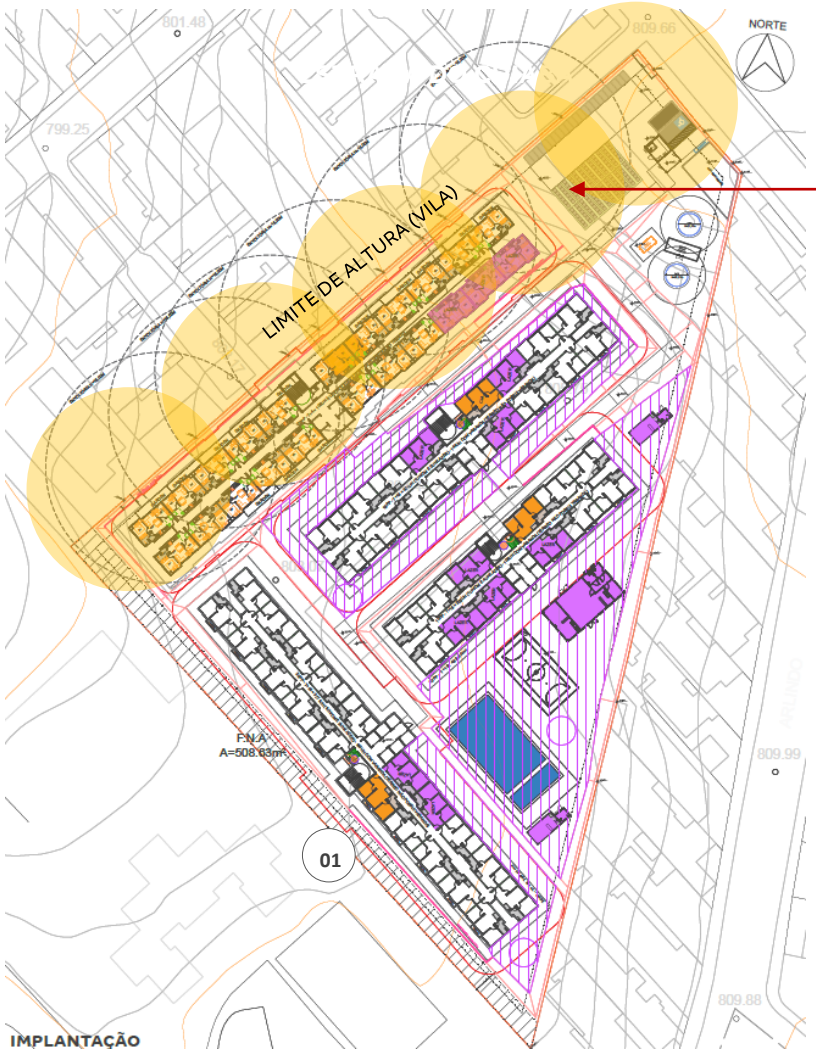

Torre T+4 para atender restrição de gabarito (15m) por envoltória de vila

ESTUDO DE MASSAS

LEGENDA:

01 FNA Existente

Área técnica

Lazer

Envoltória de vila

* Possui oportunidade de ganho de gabarito – validado por legalização.

PRODUTO

Projeto Max Berg – Comitê Essencial

	Descrição	Criticidade	Parecer
Usabilidade	**Acesso Empreendimento**	🟢	
	Percurso do pedestre até torre	🟢	
Diferencial produto	**Prime**	Não	
	Supercondomínio	Não	
	Atributos Infra	Sim	Piscina e Quadra
	Atributos Torre	Sim	432uh (43%) de Varanda *
	Edifício Garagem	Não	

	Considerações	Criticidade	Descrição
Material analisado	KMZ	🟢	
	Mapa Digital da Cidade 2004	🟡	Base desatualizada
	Matrícula	🟢	Ok
	Planialtimétrico	🟡	A contratar
Projeto	Área líquida	🟡	Base utilizada MDC (Prefeitura de São Paulo - 2004), não possuímos matrícula e planialtimétrico. Necessário base atualizada.
	Implantação	🟡	O aumento do pavimento da torre foi possível devido a quebra de gabarito pelo princípio da quadra fiscal, considerando que a quadra possui condomínios existentes com gabarito superior ao limite do zoneamento atual. Estamos utilizando a tipologia em T+4 devido à restrição de altura na lateral esquerda, onde o terreno confronta com algumas vilas.
	Drenagem	🟡	O terreno confronta com as vias das vilas existentes e podemos estudar a servidão de passagem passando por tais áreas.

* OBS.: Possibilidade de até 13 gardens na torre t+4*

Pareceres

Análise da Mancha e Implantação

Prospecção

Operações

Incorporação

Inteligência de Mercado

Financeiro

Anexos

Prospecção | Condições do Negócio

- **VALOR DO NEGÓCIO:**

- R$ 31.000.000.00 –> R$3,26 k/m2 e aproximadamente R$971/CA atingido.

- **FORMA DE PAGAMENTO: 100% Permuta Financeira.**
  - 12% líquido incidente sobre a receita bruta das vendas das unidades autônomas do Empreendimento, a ser desenvolvido no Imóvel ("Participação"), ou o recebimento do valor mínimo garantido de R$ 31.000.000,00 ("Valor Mínimo Garantido"), ou o que for maior, ("Preço, que serão quitadas em 30 (trinta) parcelas após o início das obras previsto para o 30º mês após a assinatura do contrato desde que superadas de forma integral as condições resolutivas indicadas no Capítulo VI, o qual será definido no prazo de 15 (quinze) dias antes da data prevista para a outorga da escritura de compra e venda do Imóvel,

  - **CORREÇÃO:** A partir da assinatura do CVC pelo IPCA/IBGE.

- **GARANTIAS**: Fidejussória da Tenda.

- **ESCRITURA E POSSE:** Concomitante à superação integral das resolutivas do contrato.

- **CORRETAGEM:** R$ 1.240.000,00, que representa aproximadamente 4%, por intermédio de 6 (seis) parcelas mensais, fixas e irreajustáveis.

- **PRAZOS:**

Tranches de Resolutivas:

A) I: Em até 4 meses para análises técnicas, jurídicas e financeiras. – Previsão de conclusão: dez/2025.

B) III: Em até 18 meses, a critério da COMPRADORA, ser prorrogado em até 6 (seis) meses, caso seja necessário aprovar o projeto do Empreendimento junto ao GRAPROHAB e/ou na hipótese de comprovado atraso na aprovação do projeto por parte dos órgãos competentes.

Pareceres

Análise da Mancha e Implantação

Prospecção

Operações

Incorporação

Inteligência de Mercado

Financeiro

Anexos

Custo de Construção – SIMULADOR CONSOLIDADO

PARÂMETROS					Versão:	set-25 R00
Empreendimento:	Rua Max Berg, 240				INCC base:	1.216,71
Produto / Selo:	F2E Modular	Contenção:	Nível 2		Prazo pré forma:	5,4
Pavimentos Médio:	16	Terraplenagem:	Nível 3		Prazo forma:	10,5
Torres:	4	Varanda %:	43%		Prazo pós Forma:	9,0
PPs médio:	16,5	Piscina:	Sim		Prazo total:	25,0
Unidades Construídas:	1.022	ETE:	Não		EEE:	Não

Infra Externa

Viário (m):	0	Extensão Esgoto (m):	0
Drenagem (m):	0	Extensão Água (m):	0

Obras ref. contenção

Portal Do Parque
Viva City Jaraguá F1
Life Jaguare
Palermo

Obras ref. Terraplenagem

Buritis
Farol Da Cantareira
Reserva Das Andorinhas
Viva Parque Do Carmo
Palermo

OBS.: Estudo consolidado com apoio do departamento de Planejamento e Custo de Obras

Custo de Construção – SIMULADOR CONSOLIDADO

	CUSTO	R$ / UND
CUSTO TOTAL I	**R$ 105.013.887**	**R$ 103.769**
INDIRETO	R$ 16.622.440	R$ 16.425
TORRE	R$ 63.969.832	R$ 63.211
INFRA	R$ 13.709.860	R$ 13.547
FUNDAÇÃO	R$ 8.596.720	R$ 8.495
ETE	R$ 0	R$ 0
EEE	R$ 0	R$ 0
CONTENÇÃO	R$ 183.646	R$ 181
TERRAPLENAGEM	R$ 1.931.388	R$ 1.908
CUSTO TOTAL II	**R$ 103.252**	**R$ 102**
VIÁRIO	R$ 0	R$ 0
DRENAGEM	R$ 0	R$ 0
EXTENSÃO ELÉTRICA	R$ 103.252	R$ 102
EXTENSÃO HIDRÁULICA	R$ 0	R$ 0
CUSTO TOTAL I + II	**R$ 105.117.139**	**R$ 103.871**
CUSTO TOTAL III	**R$ 0**	**R$ 0**
INCORRIDOS NÃO APROVEITADOS	R$ 0	R$ 0
CUSTO TOTAL I A III	**R$ 105.117.139**	**R$ 103.871**
CUSTO TOTAL I A IV	**R$ 105.117.139**	**R$ 103.871**

DADOS DA OBRA

Regional:	SP
Endereço:	
Total de UH:	**1.022**
Total Torres:	4
Produtos:	F2E Modular
Tipologia:	1 T+4 22PP com elevador | 3 T+18 12PP + 16PP + 20PP

BASES

Data:	setembro-25
Revisão:	R00
LPU:	LPU 94
LVS:	agosto-25
INCC:	1.216,706

PRAZOS DE OBRA

Pré Forma:	5,4 meses
Estrutura:	10,5 meses
Pós Forma:	9,0 meses
TOTAL:	**25,0 meses**
Jogos de Formas:	2
Takt:	2+2

OBS.: Estudo consolidado com apoio do departamento de Planejamento e Custo de Obras.

Custo de Construção – SIMULADOR T+4

	CUSTO	R$ / UND
CUSTO TOTAL I	**R$ 13.381.591**	**R$ 135.168**
INDIRETO	R$ 4.257.882	R$ 43.009
TORRE	R$ 5.111.516	R$ 51.631
INFRA	R$ 2.921.051	R$ 29.506
FUNDAÇÃO	R$ 894.340	R$ 9.034
ETE	R$ 0	R$ 0
EEE	R$ 0	R$ 0
CONTENÇÃO	R$ 27.757	R$ 280
TERRAPLENAGEM	R$ 169.045	R$ 1.708
CUSTO TOTAL II	**R$ 103.252**	**R$ 1.043**
VIÁRIO	R$ 0	R$ 0
DRENAGEM	R$ 0	R$ 0
EXTENSÃO ELÉTRICA	R$ 103.252	R$ 1.043
EXTENSÃO HIDRÁULICA	R$ 0	R$ 0
CUSTO TOTAL I + II	**R$ 13.484.842**	**R$ 136.211**
CUSTO TOTAL III	**R$ 0**	**R$ 0**
INCORRIDOS NÃO APROVEITADOS	R$ 0	R$ 0
CUSTO TOTAL I A III	**R$ 13.484.842**	**R$ 136.211**
CUSTO TOTAL I A IV	**R$ 13.484.842**	**R$ 136.211**

- **Utilizamos apenas o custo de torre T+4.**

DADOS DA OBRA	
Regional:	SP
Endereço:	
Total de UH:	**100**
Total Torres:	1
Produtos:	F2 Modular
Tipologia:	22PP T+4

BASES	
Data:	setembro-25
Revisão:	R00
LPU:	LPU 94
LVS:	agosto-25
INCC:	1.216,706

PRAZOS DE OBRA	
Pré Forma:	4,2 meses
Estrutura:	1,0 meses
Pós Forma:	9,0 meses
TOTAL:	**15,0 meses**
Jogos de Formas:	2
Takt:	2+2

OBS.: Estudo consolidado com apoio do departamento de Planejamento e Custo de Obras.

Custo de Construção – SIMULADOR T+18

	CUSTO	R$ / UND
CUSTO TOTAL I	**R$ 92.487.067**	**R$ 102.422**
INDIRETO	R$ 15.224.821	R$ 16.860
TORRE	R$ 58.858.316	R$ 65.181
INFRA	R$ 9.289.987	R$ 10.288
FUNDAÇÃO	R$ 7.671.437	R$ 8.496
ETE	R$ 0	R$ 0
EEE	R$ 0	R$ 0
CONTENÇÃO	R$ 432.648	R$ 479
TERRAPLENAGEM	R$ 1.009.858	R$ 1.118
CUSTO TOTAL II	**R$ 103.252**	**R$ 114**
VIÁRIO	R$ 0	R$ 0
DRENAGEM	R$ 0	R$ 0
EXTENSÃO ELÉTRICA	R$ 103.252	R$ 114
EXTENSÃO HIDRÁULICA	R$ 0	R$ 0
CUSTO TOTAL I + II	**R$ 92.590.319**	**R$ 102.536**
CUSTO TOTAL III	**R$ 0**	**R$ 0**
INCORRIDOS NÃO APROVEITADOS	R$ 0	R$ 0
CUSTO TOTAL I A III	**R$ 92.590.319**	**R$ 102.536**
CUSTO TOTAL I A IV	**R$ 92.590.319**	**R$ 102.536**

- **Utilizamos apenas o custo de torre T+18.**

DADOS DA OBRA

Regional:	SP
Endereço:	
Total de UH:	**912**
Total Torres:	3
Produtos:	F2E+ Modular
Tipologia:	16PP T+18 | 12PP T+18 | 20PP T+18

BASES

Data:	setembro-25
Revisão:	R00
LPU:	LPU 94
LVS:	agosto-25
INCC:	1.216,706

PRAZOS DE OBRA

Pré Forma:	5,7 meses
Estrutura:	9,4 meses
Pós Forma:	9,0 meses
TOTAL:	**25,0 meses**
Jogos de Formas:	2
Takt:	2+2

OBS.: Estudo consolidado com apoio do departamento de Planejamento e Custo de Obras.

Prospecção | Custo de Construção – ÁGUA, ESGOTO E GÁS

Visita ao local



Google Earth Pro

ÁGUA

ESGOTO

GÁS

Pareceres

Análise da Mancha e Implantação

Prospecção

Operações

Incorporação

Inteligência de Mercado

Financeiro

Anexos

AMBIENTAL + LEGALIZAÇÃO – Paramétrico de custos

DADOS	
Quantidade de unidades	1.006
O Empreendimento terá R2V?	NÃO
Qual a área do Terreno?	9.502
Quanto % do terreno Possui árvore?	18%
Possível Área Contaminada?	SIM
Esta Cadastrado como Área Possivelmente Contaminada nos Orgão Publicos?	SIM
Parcelamento do Solo?	NÃO
Quantos Condomínios?	1

ABERTURA	$ FINAL	
Compensação Ambiental	R$	403.768
Laudos, EIV, EIARIMA	R$	15.000
Emolumentos e Taxas	R$	35.000
Assessorias	R$	5.000
Cópias, Plotagens, Autenticações, etc...	R$	15.000
Contra Partida	R$	632.953
Projeto de criação e Legal	R$	14.000

JURÍDICO – Paramétrico de custos

DADOS	
Quantidade Unidades	1.006
Área Construída	39.989 m²
Tem SQL?	SIM
Valor do carne de IPTU	R$ 183.116
Área de Matrícula	9.502
Retificação?	SIM
Quantos Condomínios?	1
Quantos Proprietários de terreno?	1
Parcelamento do Solo?	NÃO
Remembramento de Matrículas?	NÃO
Com qual valor o terreno será escriturado?	R$ 31.000.000

ABERTURA	$ FINAL	
Desdobro de IPTU	R$	2.500
Instituição de Condomínio	R$	1.257.500
Averbação da Construção	R$	302.313
Procuração Societária	R$	5.000
IPTU (Anual)	R$	183.116
Registro de Incorporação	R$	311.260
Honorário Incorporação	R$	-
Cópias e Autenticações	R$	15.000
Honorário Aquisição	R$	80.000
Registro de Escritura	R$	232.500
ITBI Terreno	R$	930.000
Total	**R$**	**3.319.189**

Escritura de CV: R$ 57.316,75
Registro da escritura de CV: R$ 52.239,00
Escritura de CD: R$ 34.390,05

- Despesas já realizadas: R$16.340,00 (honorários de aquisição) *Considerado nas despesas de incorridos.

CRONOGRAMA PRÉVIO – Prazos de aprovação

APROVAÇÃO DE CONDOMÍNIO
TERRENO <20.000 - PROCESSO ORDINÁRIO
ANÁLISE GRAPROHAB > 800UH
COM ÁREA CONTAMINADA
IPHAN - Ñ SE APLICA
SEM RETIFICAÇÃO

PRAZO
22 meses

CIE — CIA — L

MÊS	RESP	ETAPA	STATUS/ PRAZO (dias)	0	1	2	3	4	5	6	7	8	9	10	11	12	13	14	15	16	17	18	19	20	21	22	23
0	**PROSP**	**COMITÊ INVESTIMENTO ESSENCIAL**	**-**																								
	NEG	REUNIÃO PASSAGEM/ PARTIDA	-																								
	NEG	PLANIALTIMÉTRICO	30																								
	NEG	DIRETRIZ SABESP	45																								
	PRÉ-LEG	INVESTIGAÇÃO AMBIENTAL	120																								
	DPP	ELABORAÇÃO AP	20																								
	CUSTOS	PARAMETRIZAÇÃO	20																								
	NEG	CONFIRMAÇÃO FINANCEIRA	10																								
	NEG/LEG	APROVAÇÃO COMAER	60																								
	NEG/LEG	CONSULTA CAEHIS - QUEBRA DE GABARITO	60																								
6	**NEG**	**COMITÊ INVESTIMENTO AMPLIADO**	**-**																								
	GETEC	ENGENHARIA SIMULTÂNEA	45																								
	GETEC	ELABORAÇÃO PROJETO SABESP	30																								
	GETEC	APROVAÇÃO SABESP	120																								
	GETEC	EP KIT LEGAL	126																								
	PL	ELABORAÇÃO PL	45																								
	LEG	CETESB (CONTAMINADO)	180																								
	LEG	ALVARÁ DE APROVAÇÃO E EXECUÇÃO	365																								
	LEG	ANÁLISE DE GRAPROHAB	120																								
	NEG	**COMITÊ DE ESCRITURA/ LANÇAMENTO**	-																								
	JRI	ESCRITURA	30																								
	JRI	REGISTRO INCORPORAÇÃO	30																								
	CRD	LAUDOS CEF	90																								
22	**NEG**	**LANÇAMENTO**	**-**																								

Pareceres

Análise da Mancha e Implantação

Prospecção

Operações

Incorporação

Inteligência de Mercado

Financeiro

Anexos

Demanda e Distribuição da Mancha

Potencial de Demanda			Lançados		Lançados + Landbank	
Mancha	CÓD.	Shr.	ANO	MÊS	ANO	MÊS
São Paulo Sul	SZS	21%	1.459	122	1.750	146

Empreendimento	Renda	Lançamento	nov/27	dez/27	jan/28	fev/28	mar/28	abr/28	mai/28	jun/28	jul/28	ago/28	set/28	out/28	nov/28	dez/28	jan/29	fev/29	mar/29	abr/29	mai/29
Essência Do Campo Fase 1	3.584	jul-26	31	31	23																
Essência Do Campo Fase 2	3.584	jul-27	20	20	20	20	20	20	20	20	20	20	20	20	20	20	14				
Americanópolis	4.495	ago-27	38	38	38	38	38	38	38	38	38	38	38	38	38	38	38	38	23		
Max Berg	**4.442**	**nov-27**		**56**	**56**	**56**	**56**	**56**	**56**	**56**	**56**	**56**	**56**	**56**	**56**	**56**	**56**	**56**	**56**	**56**	**54**
Moove Santo Amaro	3.266	abr-29																			55
Total de Vendas Lançados			**0**	**0**	**0**	**0**	**0**	**0**	**0**	**0**	**0**	**0**	**0**	**0**	**0**	**0**	**0**	**0**	**0**	**0**	**0**
Total de Vendas Lançados + Landbank			**89**	**145**	**137**	**114**	**114**	**114**	**114**	**114**	**114**	**114**	**114**	**114**	**114**	**114**	**108**	**94**	**79**	**56**	**109**

Parecer de I.M sobre a mancha:

O projeto analisado em comitê está em linha com o potencial teórico de demanda calculado para a mancha. (Total Lanç + Landbank)

Canibalização:

Sem Risco de Canibalização

Max Berg | Mapa Concorrência

		Max Berg	Neo Sacomã
		TENDA	Cury
	Distância Tenda (km)		250m
Região 1 Km	População	49.640	49.640
	Dens. Demográfica	15.903	15.903
	Renda (R$)	7.938	7.938
	Classe Social	B2 (4.6k a 8.1k)	B2 (4.6k a 8.1k)
	PEA Dia	31.091	31.091
Quantitativo	Lançamento	nov/27	ago/25
	Unidades	1006	732
	Estoque	1006	634
	VSO	56	98
	Stockout	18	6
Qualitativo	Condomínios	1	1
	Torres	4	4
	Gabarito	T+18	T+9
	Plantas (m²)	32m², 34m² e 41m²	34m², 37m² e 44m²
	Tipologia	2 Dorms	2 Dorms
	Opções	Não	Não
	Varanda	Sim	Não
	Vagas	4%	Sem Vagas
	Lazer	Quadra, Piscina, Play Kids, Play Baby, Pet Place, Fitnesss	Academia, Bicicletário, Brinquedoteca, Churrasqueira, Coworking, Espaço beauty, Lavanderia, Market, Pet care, Pet place, Piscina adulto, Playground, Quadra poliesportiva, Beach Tenis, Sala de jogos, Salão de Festas, Sports bar.

Farol Renda
Acima de 300
Entre 0 e 300
Abaixo de 0

Diagnóstico Concorrência

- O projeto da Cury – Neo Sacomã, possui produto competitivo ao Max Berg, com preço similar nas tipologias equiparáveis ainda mantendo o affordabillity frente a concorrência.
- VSO da concorrência equivale ao primeiro final de semana do lançamento do projeto, não tivemos atualizações sobre o mesmo até o momento.

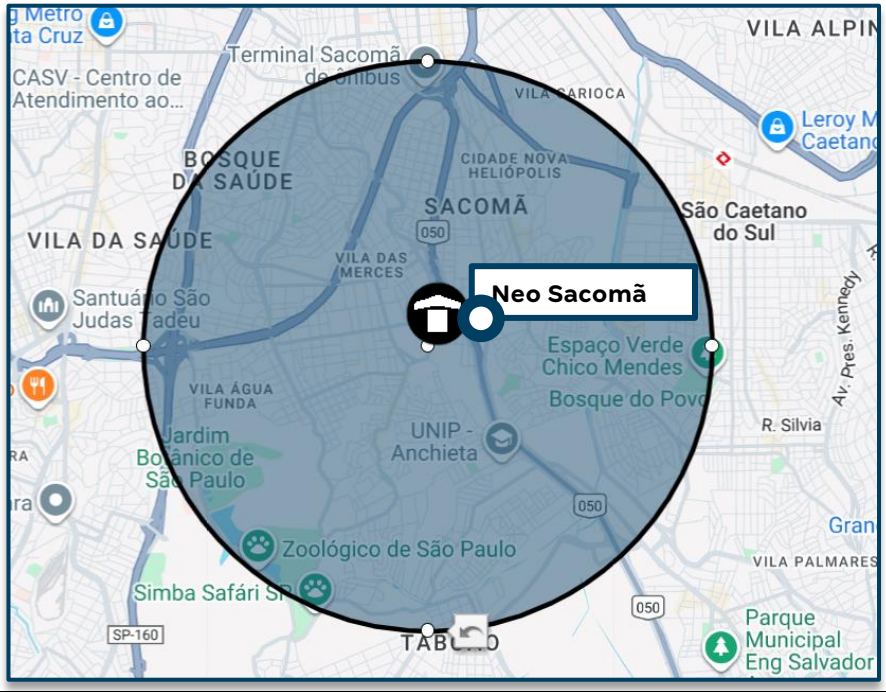

-	Max Berg					Neo Sacomã					
Tipologias	Avaliação	Preço Nominal	CEF	Renda	% Unidades	Avaliação	Preço Nominal	CEF	Renda	% Unidades	Farol
HIS	-	-	-	-	-	264.000	239.661	191.728	3.750	10%	-
HMP	290.000	250.052	194.367	3.693	57%	264.000	247.229	197.783	3.950	38%	●
Varanda	310.000	278.372	219.108	5.393	39%	297.000	291.629	233.303	5.900	52%	●
Varanda + Moto	315.000	286.405	223.597	5.609	2%	-	-	-	-	-	-
Varanda + Carro	330.000	328.362	259.815	6.503	1%	-	-	-	-	-	-

Simulação de Preço

Informações Viabilidade

Projeto:	Max Berg							
Tipo:	**HMP**		**Varanda**		**Varanda + Moto**		**Varanda + Carro**	
Método	**Vision**		**Vision**		**Vision**		**Vision**	
Avaliação	290.000		310.000		315.000		330.000	
Renda Inicial (VF)	3.693		5.393		5.609		6.503	
Renda Final*	-		-		-		-	
% RET1	25%		0%		0%		0%	
Tipo:	**VF**	**R$**	**VF**	**R$**	**VF**	**R$**	**VF**	**R$**
Ato	0,62	2.287	0,43	2.314	0,78	4.384	0,79	5.143
FGTS	0,85	3.123	0,56	3.009	0,61	3.432	0,74	4.832
Financiamento	96,38%	187.691	97,77%	216.099	96,39%	220.165	97,07%	254.983
Subsídio	154,44%	3.553	0,00%	0	0,00%	0	0,00%	0
Prazo de Pró-soluto	30	30	30	30	30	30	30	30
Pró-Soluto	79,82%	32.127	60,55%	35.594	60,55%	37.019	59,72%	42.335
Preço Raso (RS)	228.781	228.781	257.016	257.016	265.001	265.001	307.293	307.293
TCD	57,14%	21.270	39,29%	21.356	37,86%	21.404	32,14%	21.070
VSO	32	32	22	22	1	1	1	1
Preço de Venda	**250.052**	**250.052**	**278.372**	**278.372**	**286.405**	**286.405**	**328.362**	**328.362**
Elasticidade	0,000%	0,000%	0,000%	0,000%	0,000%	0,000%	0,000%	0,000%
Preço de Venda Final	**250.052**	**250.052**	**278.372**	**278.372**	**286.405**	**286.405**	**328.362**	**328.362**
Preço Raso (R$)	**228.781**		**257.016**		**265.001**		**307.293**	
% de Raso	**91,49%**		**92,33%**		**92,53%**		**93,58%**	
BP25 - Não Inflacionado	**-**		**-**		**-**		**-**	
BP25 - Inflacionado	**-**		**-**		**-**		**-**	

Análise de Preço

Informações Viabilidade

Projeto:	Max Berg
Tipo:	**Faixa 2**
Método	**Vision**
Avaliação	298.961
Renda Inicial (VF)	4.442
Renda Final*	-

Tipo:	VF	R$
Ato	0,55	2.382
FGTS	0,73	3.107
Financiamento	96,94%	200.486
Subsídio	88,12%	2.027
Prazo de Pró-soluto	30	30
Pró-Soluto	71,53%	33.735
Preço Raso (RS)	241.738	241.738
TCD	49,35%	21.305
VSO	56	56
Preço de Venda	**263.043**	**263.043**
Elasticidade	0,000%	0,000%
Preço de Venda Final	**263.043**	**263.043**
Preço Raso (R$)	**241.738**	
% de Raso	**91,90%**	
Raso Todas as Fases	**241.738**	
Nominal Todas as Fases	**263.043**	

1

Análise de Riscos	Farol IM
IM avalia o Preço Vision como **factível**.	

1) I.M está de acordo com o preço Vision, tendo em vista que, o projeto está em uma região com ótimos indicadores sociodemográficos, como renda e PEA/Dia, o mesmo também se encontra em região atrativa, com serviços essenciais próximos ao terreno. Já atuamos no target de renda estimado na mancha.
Projeto contará com diferencias de piscina, e varanda, reforçando o atrativo no mercado.

Conforme consta no slide "Panorama de Concorrência", os concorrentes da região vendem em um target de preço e renda similar ao previsto para o produto Tenda, com produtos competitivos.

	Preço Real					Preço Normalizado (30m)	
	Avaliação	Preço Raso	Renda Média	VSO	PSOL	Δ PSOL	Preço Raso
Vista Vila das Belezas	248.200	229.463	4.254	26	25	6.144	235.608
Max Berg	298.961	241.738	4.442	56	30	-	241.738

Ciclo Financeiro – Análise Mancha

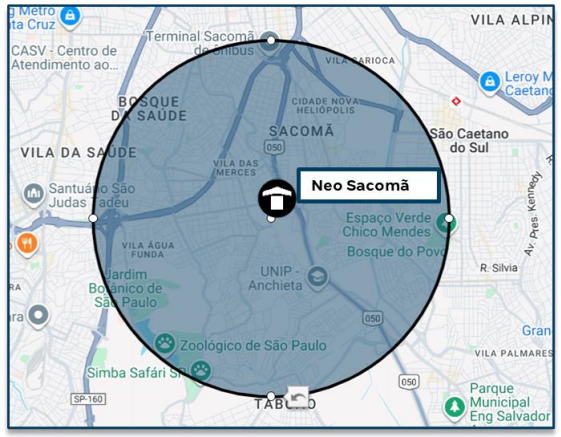

-	Max Berg					Neo Sacomã					
Tipologias	Avaliação	Preço Nominal	CEF	Renda	% Unidades	Avaliação	Preço Nominal	CEF	Renda	% Unidades	Farol
HIS	-	-	-	-	-	264.000	239.661	191.728	3.750	10%	-
HMP	290.000	250.052	194.367	3.693	56%	264.000	247.229	197.783	3.950	38%	🟡
Varanda	310.000	278.372	219.108	5.393	39%	297.000	291.629	233.303	5.900	52%	🟢
Varanda + Moto	315.000	286.405	223.597	5.609	2%	-	-	-	-	-	-
Varanda + Carro	330.000	328.362	259.815	6.503	1%	-	-	-	-	-	-

Parecer Ciclo

O Ciclo validou o preço e o VSO como viáveis. O projeto está estrategicamente localizado na região da Zona Sul. A área apresenta forte potencial de demanda e, mesmo diante da presença de concorrentes, estamos com preços competitivos.

Pareceres

Análise da Mancha e Implantação

Prospecção

Operações

Incorporação

Inteligência de Mercado

Financeiro

Anexos

Informações Financeiras

MAX BERG ESSENCIAL – SP – São Paulo Capital

Datas e Prazos

	Compra	Lançamento	Início Obra	Término Obra	LÇTO até IO	IO até TO	Chaves	LÇTO até Chaves
Consolidado	jan-26							
S/ VARANDA		nov-27	mai-28	jun-30	6 meses	25 meses	nov-30	36 meses
C/ VARANDA		nov-27	mai-28	jun-30	6 meses	25 meses	nov-30	36 meses
C/ VARANDA E VAGA MOTO		nov-27	mai-28	jun-30	6 meses	25 meses	nov-30	36 meses
C/ VARANDA E VAGA CARRO		nov-27	mai-28	jun-30	6 meses	25 meses	nov-30	36 meses
S/ VARANDA T+4 C/ elevador		nov-27	mai-28	jun-30	6 meses	25 meses	nov-30	36 meses

Terreno e Incorridos

TOTAL (R$ + Perm.):	31,75 MM	**Incorrido Terreno:**	0,00 MM	**Área do Terreno (100%):**	9.501 m²
Cash:	0,00 MM	**Nº de Parcelas Cash :**	0	**Custo de terreno m²:**	3.342,1
Permuta Financeira:	31,75 MM (12,00%)			**VaR 25 (R$ mil):**	0
Permuta Física:	0,00 MM (0,00%)			**VaR 26 (R$ mil):**	0
Ato / %VGV:	0,00 MM / 0,0%			**Incorrido de Construção:**	0,00 MM

Área Líquida do Terreno:	8.993 m²
Custo de terreno m² Área Líquida:	3.531,2
Fração Terreno/Terreno + Custo Obra (%VGV):	12,0% / 51,5%
CA Máx/Proj.	5,4 / 3,4
Incorridos de Incorporação:	0,02 MM

Vendas

Fases	Nº Pavimentos	Preço Raso Unit.	Qtde	Preço Unit.	Aval. CEF	Cond. Parcela	% Pró-soluto	% TCD
S/ VARANDA	T+18	228.813	468	250.052	290.000	96,4%	79,8%	57,1%
C/ VARANDA	T+18	257.032	396	278.372	310.000	97,8%	60,6%	39,3%
C/ VARANDA E VAGA MOTO	T+18	265.001	23	286.405	315.000	96,4%	60,6%	37,9%
C/ VARANDA E VAGA CARRO	T+18	307.292	13	328.362	330.000	97,1%	59,7%	32,1%
S/ VARANDA T+4 C/ elevador	T+4	228.859	106	250.052	290.000	96,4%	79,8%	57,1%

Unidades Totais:	1.006	**Preço Médio:**	263.043	**Renda Média:**	4.442	**ITBI+Emol. Unit. Médio:**	7.835
Unidades Tenda:	1.006	**Avaliação Média:**	298.961	**Ato:**	2.448 (0,55 Salários)	**Custo do Ciclo Unit.:**	16.558
VSO:	56 Unidades	**VGV Total:**	264.621.181	**FGTS:**	3.239 (0,73 Salários)	**Preço Raso Médio:**	241.767
RET Médio:	3,6%	**VGV Tenda:**	264.621.181	**% em RET 1%:**	14%	**Adc. Tx. de Aceleração Médio:**	750

Construção

Custo Total Unit. | Corrigido:	103.871 | 103.339	**Eventuais:**	4,00%	**Área priv (m²):**	33,61	**Gape / Mês Unit.:**	11,08

Resultado

LI (R$):	**28.038.502**	**LI:**	**19,60%**	**Exposição de Caixa (R$):**	**20.481.777**	**Margem Bruta Econômica:**	**38,03%**
TIR:	**160,81%**	**LI Aprovação:**	**20,00%**	**Ger. Caixa 12 meses (R$):**	**0**	**Margem Bruta REF:**	**41,36%**
Exposição de Caixa:	**7,00%**	**Δ LI:**	**-0,40%**	**Ger. Caixa 24 meses (R$):**	**(416.841)**	**Margem Rasa Econômica:**	**31,80%**
Payback Contingente (21 m):	**19 m/ (-2 m)**	**LI Resiliência:**	**7,81%**	**Ger. Caixa Marginal (R$):**	**68.538.611**	**Margem Rasa REF:**	**36,21%**
Payback Consolidado:	**19 meses**					**Margem de Contribuição Econômica:**	**25,52%**

DRE (Consolidado)

R$ Mil - Valores Nominais - Compra	MAX BERG ESSENCIAL		S/ VARANDA		C/ VARANDA		C/ VARANDA E VAGA MOTO		C/ VARANDA E VAGA CARRO		S/ VARANDA T+4 C/ elevador	
	Nominal	%	Nominal	%	Nominal	%	Nominal	%	Nominal	%	Nominal	%
Receita	292.776	100,0%	129.517	100,0%	121.920	100,0%	7.239	100,0%	4.752	100,0%	29.349	100,0%
PIS/COFINS	(5.769)	2,0%	(2.308)	1,8%	(2.674)	2,2%	(159)	2,2%	(104)	2,2%	(523)	1,8%
Custo Total	(177.845)	62,0%	(81.728)	64,2%	(70.964)	59,5%	(4.155)	58,7%	(2.454)	52,8%	(18.544)	64,3%
Custo Terreno	(38.167)	13,3%	(16.813)	13,2%	(15.963)	13,4%	(951)	13,4%	(630)	13,5%	(3.810)	13,2%
Custo Relacionados a Terreno	(3.017)	1,1%	(1.375)	1,1%	(1.216)	1,0%	(71)	1,0%	(43)	0,9%	(311)	1,1%
Custos de Incorporação	(5.326)	1,9%	(2.442)	1,9%	(2.086)	1,7%	(130)	1,8%	(84)	1,8%	(584)	2,0%
Custo de Construção	(131.336)	45,8%	(61.099)	48,0%	(51.699)	43,4%	(3.003)	42,4%	(1.697)	36,5%	(13.839)	48,0%
Lucro Bruto Econômico	109.162	38,0%	45.480	35,8%	48.281	40,5%	2.925	41,3%	2.194	47,2%	10.282	35,7%
Custo para Rateio	-	0,0%	-	0,0%	-	0,0%	-	0,0%	-	0,0%	-	0,0%
Lucro Bruto Contábil	109.162	38,0%	45.480	35,8%	48.281	40,5%	2.925	41,3%	2.194	47,2%	10.282	35,7%
Despesas de Selling	(29.187)	10,2%	(12.880)	10,1%	(12.190)	10,2%	(730)	10,3%	(471)	10,1%	(2.917)	10,1%
Contingência	(6.734)	2,3%	(2.979)	2,3%	(2.804)	2,4%	(167)	2,4%	(109)	2,4%	(675)	2,3%
Margem de Contribuição	73.242	25,5%	29.621	23,3%	33.287	27,9%	2.029	28,7%	1.614	34,7%	6.690	23,2%
IR e CSLL	(4.720)	1,6%	(1.889)	1,5%	(2.188)	1,8%	(130)	1,8%	(85)	1,8%	(428)	1,5%
Margem Líquida	68.522	23,9%	27.733	21,8%	31.099	26,1%	1.899	26,8%	1.529	32,9%	6.262	21,7%
Lucro Bruto REF Unit.	123.773	41,4%	111.074	39,0%	138.767	43,8%	148.255	45,3%	185.023	49,8%	110.996	39,0%
Lucro Raso REF Unit.	99.604	36,2%	86.944	33,4%	114.525	39,2%	123.862	40,9%	161.322	46,4%	86.927	33,4%

R$ Mil - VPL - Compra	MAX BERG ESSENCIAL		S/ VARANDA		C/ VARANDA		C/ VARANDA E VAGA MOTO		C/ VARANDA E VAGA CARRO		S/ VARANDA T+4 C/ elevador	
	VP	%	VP	%	VP	%	VP	%	VP	%	VP	%
Receitas	143.080	100,0%	63.194	100,0%	59.750	100,0%	3.467	100,0%	2.371	100,0%	14.298	100,0%
PIS/COFINS	(2.777)	1,9%	(1.109)	1,8%	(1.291)	2,2%	(75)	2,2%	(51)	2,2%	(251)	1,8%
Custos e Despesas Totais	(112.264)	78,5%	(51.139)	80,9%	(45.270)	75,8%	(2.638)	76,1%	(1.616)	68,2%	(11.601)	81,1%
Custo Terreno	(18.201)	12,7%	(8.022)	12,7%	(7.616)	12,7%	(444)	12,8%	(303)	12,8%	(1.815)	12,7%
Custo Relacionados a Terreno	(1.966)	1,4%	(896)	1,4%	(793)	1,3%	(47)	1,3%	(28)	1,2%	(203)	1,4%
Custos de Incorporação	(2.939)	2,1%	(1.344)	2,1%	(1.149)	1,9%	(74)	2,1%	(49)	2,1%	(323)	2,3%
Custo de Construção	(67.896)	47,5%	(31.586)	50,0%	(26.727)	44,7%	(1.552)	44,8%	(877)	37,0%	(7.154)	50,0%
Despesas de Selling	(17.333)	12,1%	(7.650)	12,1%	(7.240)	12,1%	(419)	12,1%	(289)	12,2%	(1.735)	12,1%
Contingência	(1.657)	1,2%	(733)	1,2%	(690)	1,2%	(41)	1,2%	(27)	1,1%	(166)	1,2%
IR e CSLL	(2.272)	1,6%	(908)	1,4%	(1.056)	1,8%	(61)	1,8%	(42)	1,8%	(205)	1,4%
Lucro Imobiliário	28.039	19,6%	10.946	17,3%	13.189	22,1%	754	21,7%	704	29,7%	2.446	17,1%

DRE (Fase)

R$ Mil - Valores Nominais - Compra	MAX BERG ESSENCIAL		Primeira Fase	
	Nominal	%	Nominal	%
Receita	292.776	100,0%	292.776	100,0%
PIS/COFINS	(5.769)	2,0%	(5.769)	2,0%
Custo Total	(177.845)	62,0%	(177.845)	62,0%
Custo Terreno	(38.167)	13,3%	(38.167)	13,3%
Custo Relacionados a Terreno	(3.017)	1,1%	(3.017)	1,1%
Custos de Incorporação	(5.326)	1,9%	(5.326)	1,9%
Custo de Construção	(131.336)	45,8%	(131.336)	45,8%
Lucro Bruto Econômico	109.162	38,0%	109.162	38,0%
Custo para Rateio	-	0,0%	-	0,0%
Lucro Bruto Contábil	109.162	38,0%	109.162	38,0%
Despesas de Selling	(29.187)	10,2%	(29.187)	10,2%
Contingência	(6.734)	2,3%	(6.734)	2,3%
Margem de Contribuição	73.242	25,5%	73.242	25,5%
IR e CSLL	(4.720)	1,6%	(4.720)	1,6%
Margem Líquida	68.522	23,9%	68.522	23,9%
Lucro Bruto REF Unit.	123.773	41,4%	123.773	41,4%
Lucro Raso REF Unit.	99.604	36,2%	99.604	36,2%

R$ Mil - VPL - Compra	MAX BERG ESSENCIAL		Primeira Fase	
	VP	%	VP	%
Receitas	143.080	100,0%	143.080	100,0%
PIS/COFINS	(2.777)	1,9%	(2.777)	1,9%
Custos e Despesas Totais	(112.264)	78,5%	(112.264)	78,5%
Custo Terreno	(18.201)	12,7%	(18.201)	12,7%
Custo Relacionados a Terreno	(1.966)	1,4%	(1.966)	1,4%
Custos de Incorporação	(2.939)	2,1%	(2.939)	2,1%
Custo de Construção	(67.896)	47,5%	(67.896)	47,5%
Despesas de Selling	(17.333)	12,1%	(17.333)	12,1%
Contingência	(1.657)	1,2%	(1.657)	1,2%
IR e CSLL	(2.272)	1,6%	(2.272)	1,6%
Lucro Imobiliário	28.039	19,6%	28.039	19,6%

Pareceres

Análise da Mancha e Implantação

Prospecção

Operações

Incorporação

Inteligência de Mercado

Financeiro

Anexos

- **DESCRIÇÃO DOS IMÓVEIS: Matrículas:** 245.222 do 14º Oficial de Registro de Imóveis de São Paulo/SP, situadas na Av. Max Berg, nº 240, no Vila das Mercês. **Contribuinte**: 049.143.0040-0.

- **PROPRIETÁRIOS:** APM Investimentos e Participações Ltda ("APM"), AROMA EMPREENDIMENTOS LTDA ("AROMA"), MPF INVESTIMENTOS E PARTICIPAÇÕES LTDA ("MPF"), GLARANDA PARTICIPAÇÕES LTDA ("GLARANDA"), KIMORA S/A ("KIMORA"), PORTO SANTO HOLDING PATRIMONIAL LTDA ("PORTO SANTO"), BEATRICE INVESTIMENTOS E PARTICIPAÇÕES LTDA ("BEATRICE"), SHIRLEI APARECIDA SOUZA VIDEIRA ("SHIRLEI") e ALPHA STAR EMPREENDIMENTOS LTDA ("ALPHA").

- **CONSIDERAÇÕES SOBRE O IMÓVEL: ESTUDOS TÉCNICOS E JURÍDICOS**: Será analisado a necessidade em retificar a área, no ato da contratação de profissional capacitado para a realização de estudos técnicos; **(a) Loteamento:** Providenciaremos as certidões do imóvel até a origem (transcrição) para verificarmos se o imóvel atual foi objeto de loteamento no passado e em caso positivo verificaremos eventuais restrições; **DD Imóvel**: **(b) Área construída**: Verifica-se uma divergência entre a área de terreno registrada — 9.047,22 m² — e a área indicada no cadastro municipal, que corresponde a 8.800 m², a referida regularização será providenciada no momento oportuno; **(c) Débitos Imobiliários**: Não há até a presente data, somente parcelas vincendas de julho, agosto, setembro, outubro e novembro de 2025 que perfazem o montante de R$ 89.288,95; **(d) Multas:** Não há; **(e) Ônus e Gravames**: Não há; **(f) Ocupação**: O imóvel é ocupado pelos vendedores; **(g) TAC**: Não há; **(h) CONDEPHAAT, CONPRESP, IPHAN:** As certidões são negativas; **(i) DESAP:** Negativa; **(l) Função Social da Propriedade:** O imóvel ocupado, logo cumpre com a função social prevista na Constituição Federal, ou seja, fazer o uso diário do imóvel.

➢ **CONSIDERAÇÕES SOBRE OS PROPRIETÁRIOS:**

- **A) SHIRLEI APARECIDA SOUZA VIDEIRA**
- **i)** Processos: 1016507-54.2016.8.26.0100 - Ação: Execução de Título Extrajudicial – Valor da causa: R$ 41.858,38

- **B) CARLOS ALBERTO RISSO**
- **i)** Processos Justiça do Trabalho**:** Foram localizados 13 processos totalizando o valor aproximado de R$ 1.390.000,00
- **ii)** Processos Justiça Federal: Foram localizados 5 processos, dos quais dois tramitam na Vara Criminal. Todos estão sobrestados e são antigos.
- **Iii)** Processos Justiça Estadual: Foram localizados 25 processos totalizando o valor aproximado de R$ 200.000,00

- **B) SANTA AMELIA PARTICIPACOES LTDA**
- **i)** Processos Justiça do Trabalho: 1001241-81.2018.5.02.0712 - Valor da causa: R$ 931.215,41
- **ii)** Processos Justiça Estadual: 0613893-45.2014.8.26.0090. Ação: Execução Fiscal. Assunto: ISS/ Imposto sobre Serviços – Valor da causa: R$ 16.617,30

- **C) AROMA EMPREENDIMENTOS LTDA**
- **i)** Processos Justiça do Trabalho: 0032000-83.2008.5.02.0069 – Valor da causa: R$ 40.000,00
- **ii)** Processos Justiça Estadual: 1016125-76.2024.8.26.0554. Assunto: Indenização por Dano Moral – Valor R$ 54.547,08.
- **Iii)** Certidão Negativa da Receita Federal: Positiva com efeito de Negativa, deverá ser apresentado o extrato de débitos.

- **D) MPF INVESTIMENTOS E PARTICIPACOES EIRELI:** As certidões são Negativas.

- **E) GLARANDA PARTICIPAÇÕES LTDA**
- **i)** Processos Justiça Estadual: 1032645-57.2020.8.26.0100. Valor da causa: R$ 763.207,00
- **Iii)** Certidão Negativa da Receita Federal: Positiva com efeito de Negativa, deverá ser apresentado o extrato de débitos.

- **F) KIMORA S/A**
- **i)** Certidão Negativa da Receita Federal: Positiva com efeito de Negativa, deverá ser apresentado o extrato de débitos.

- **G) PORTO SANTO HOLDING PATRIMONIAL LTDA:** As certidões são Negativas.

- **H) BEATRICE PARTICIPACOES E INVESTIMENTOS LTDA:** As certidões são Negativas.

- **I) ALPHA STAR – EMPREENDIMENTOS LTDA**
- **i)** Processos Justiça do Trabalho: 0071600-96.2003.5.02.0066 - R$ 10.000,00

➢ **CONCLUSÃO:** O imóvel foi incorporado pela empresa APM – Investimentos e Participações Ltda., contudo, a averbação correspondente ainda não consta na matrícula. A partir de análise prévia, verificamos que ao menos parte das empresas proprietárias, inclusive a própria APM, integra o Grupo Ruas, composto por aproximadamente 50 empresas, entre as quais se destacam a Caio Induscar e outras atuantes no setor de transporte coletivo, como a Viação Campo Belo, esta última sócia da APM. Diante desse cenário, entendemos que, na fase de due diligence, será necessário estender a auditoria às demais empresas do Grupo Ruas e/ou a seus respectivos sócios, considerando tanto a quantidade de sociedades envolvidas quanto os apontamentos identificados. Ainda no âmbito da due diligence, deverá ser verificado se os ativos dos coproprietários são suficientes para a cobertura de eventuais passivos.

Legalização

- **ÁREA DE IMPLANTAÇÃO**
- O terreno é composto por 1 matrícula (14º ORI), em nome de pessoa física, que totaliza uma área escriturária de 9.502,48m²;
- O cadastro do imóvel é urbano;
- O cenário foi desenvolvido sobre a poligonal do MDC definida 9.501,29m².
- O terreno apresenta uma FNA passando aos fundos. Desta forma, a área líquida final é de 8.992,66m²
- Rua Conforme Geosampa: Aproximadamente 8,00m.
- **DIRETRIZES URBANÍSTICAS**
- O terreno esta inserido em ZM, conforme decreto 63.728/2024:
  - C.A. máximo: 3,00 para EHIS, 2,5 para EHMP, com restrição de gabarito de 28,00m, que iremos quebrar dado a altura das demais edificações da quadra (LPUOS – Art. 60, item II), TO 70% e PA 6 (20%), necessário reserva de calçada.
  - Benefícios: Incentivo HIS (50% do CA máx.) = 1,5 + Cota de Solidariedade (30% do CA máx.) = 0,90
- Terreno não terá parcelamento.
- O estudo considera implantação de 1 condomínio com 4 torres, sendo:
  - 1 torre 12 PP, 1 torre16PP, ambas com 19 pavimentos. 01 torre 20PP com 19 pavimentos e 01 torre 22PP com 5 pavimentos, totalizando **1.006UH** – Destas, **106 unidades são de incentivo HIS-1, chegando a um CA virtual de 3,36;**
- Em função do zoneamento não é exigido cota a parte;
- A legislação não exige vaga de garagem, cenário não considera vagas;
- Usos permitidos: EHIS e EHMP.
- **GRAPROHAB**
- Numero de UH do estudo (EM) supera o 800 UH, sendo necessário a aprovação;

Legalização | Quebra de Gabarito – Princípio Quadra Fiscal

IMAGENS CONDS EXISTENTES: GOOGLE EARTH PRO

Conforme 16.402/16, segue: Art. 60. O gabarito de altura máxima (GAB) da edificação será o definido no Quadro 3 desta lei, exceto:
II - nas quadras nas quais em mais de 50% (cinquenta por cento) da área dos lotes as edificações existentes já tenham ultrapassado os limites previstos no referido quadro."

PROJETO TENDA JÁ APROVADO COM QUEBRA DE GABARITO: Vista Villa Lobos

REGRA ADOTADA:

- Quadra fiscal com aproximadamente: 119 mil m²
- Lotes ocupados por condomínios com gabarito superior ao zoneamento atual: 66 mil m² - representando ~55% da quadra
- Quadra verticalizada acima do limite: 50% -> Ok, atende ao ART. 60 da Lei 16.402/16

➢ AVALIAÇÕES AMBIENTAIS

Arbóreo

- Conforme consulta ao GeoSampa, o terreno **não** é considerado como Patrimônio Ambiental
- **Não** incide sobre o terreno APP;
- Necessário laudo arbóreo para confirmação de existência de fragmento;
- Para cenário de comitê, conforme parametrização enviada, foi considerado 18% de incidência arbórea.
- A propriedade não está inserida em Área de Patrimônio Ambiental (APA), Área de Proteção de Mananciais (APRM) e Unidade de Conservação;
- Cenário considera a supressão de todos os exemplares localizados no interior do lote;
- Compensação de 1:10 (HIS e HMP), para cenário R2v seguir legislação;

Hidrografia

- O Imóvel não apresenta corpos d'água internos ao perímetro ou próximo;
- Córrego mais próximo a cerca de 206 m do imóvel;

➢ AVALIAÇÕES AMBIENTAIS

Contaminação (Contaminado)

1- Conforme consulta ao GeoGegran, o terreno é classificado como Área Reabilitada Para Uso Declarado. Porém, faz-se necessária a análise dos documentos protocolados para entender qual o uso foi declarado, bem como é necessária a realização de novos Laudos para comprovação.

Para efeito de comitê essencial foi considerado o terreno como contaminado, devido as atividades exercidas no terreno (uso pretérito) e o cadastro em CETESB.

- **ÓRGÃOS DE PATRIMÔNIO HISTÓRICO**

- De acordo com a certidão CIT, o imóvel é isento de aprovação perante ao CONPRESP, CONDEPHAAT, UPPH e DPH;

- **URBANIZAÇÃO**

- Não consta DUP/DIS ou ação visando a desapropriação do imóvel, bem como o mesmo não é atingido por plano de melhoramento viário ou sanitários;
- Conforme croqui patrimonial, não consta área pública no imóvel;

- **OUTROS ITENS NECESSÁRIOS/ESPECÍFICOS**

- Há edificações a serem demolida no terreno;

Obrigado (a)