Tenda

sua próxima conquista

Comitê de escritura e lançamento

Regional: RMSP – Santo André

Projeto: Adriático (Panorama Santo André)

Data Comitê: 25/09/2025

Comitê Digital 22.09.2025

Nome	Panorama Santo André - Escritura + Lançamento	Observação - Panorama Santo André
Renan Barbosa Sanches	Aprovado	Ok
Andre Luis Menegazzo Padilha	Aprovado	ok
Alexandre Regis de Oliveira	Aprovado	ok
Fabricio Quesiti Arrivabene	Aprovado	Precisamos melhorar a avaliação.
Alejandro Octavio Abiusi	Aprovado	ok
Luiz Mauricio de Garcia Paula	Aprovado	ok
Rodrigo Osmo	Discutir em comitê	(1) O edifício garagem teria um único elevador de acesso às torres?;

1. **O edifício garagem teria um único elevador de acesso às torres?**

Resposta: Sim, o projeto foi concebido com um elevador com função de transfer, conectando o edifício garagem ao platô do Bloco 1 e vencendo o desnível de 6,65 metros (equivalente a dois pavimentos). Trata-se da **rota acessível**, enquanto o **acesso principal se dá por meio de uma caixa de escadas**. Ressalta-se que não existe norma específica para o dimensionamento de elevadores de transfer; contudo, o equipamento está sendo **especificado para uso irrestrito**, com capacidade para 8 passageiros e velocidade de 1,5 m/s.

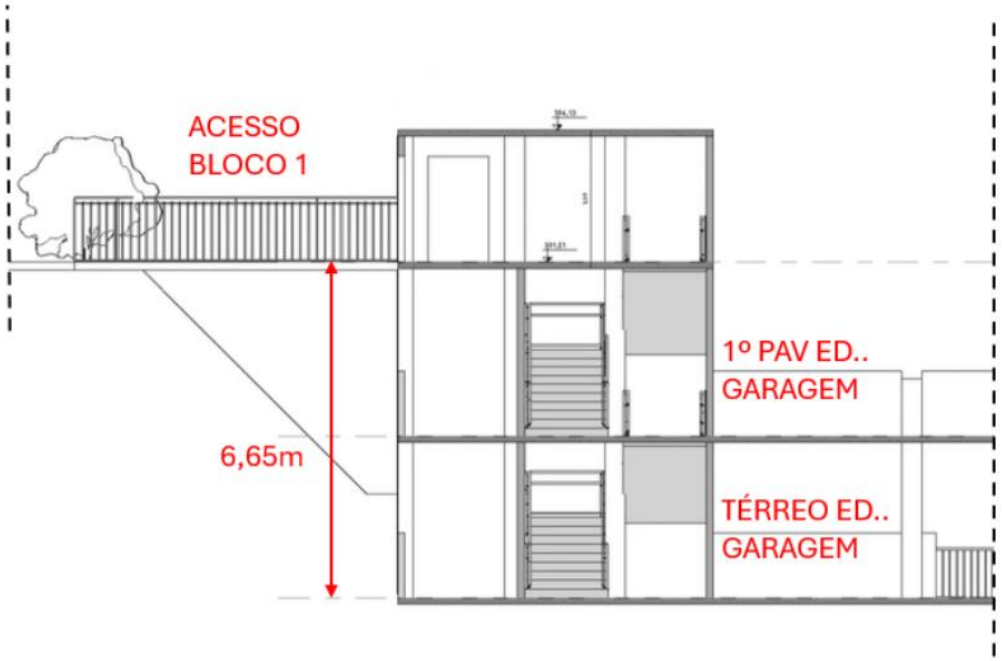

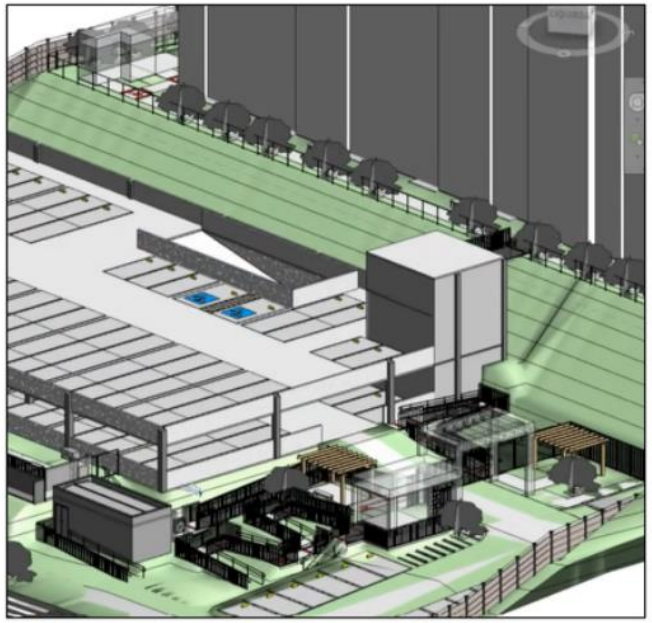

One Page – Panorama Santo André – Aprovação

	Cidade	Santo André	**Mancha de demanda**	SPRM - ABCD - ABCD
	Regional	SPRM	**Cluster MPR**	2 - Amarelo
[1]	**Cenário de Aprovação**	Aprovação	**Tipo de Aprovação**	Consolidado
	Fase Anterior	N/A		
	Tipo de Comitê	Escritura e Lançamento	**Versão da VF**	Versão 1.0: Set

Unidades (Fases)	642 (1)	**CA Máx | Proj**	4,5 | 2,4
Unidades com Vaga (%)	216 (34%)	**Escritura | Lançamento**	set/25 | out/25
Unidades com Varandas (%)	306 (47,7%)	**Tipologia**	F2E Plus - CDW

Valor Líquido do Terreno (% VGV)	14.000 (8,0%)	**Un. Perm. Fís (% Ter)**	0 (0,0%)
Cash (Correção)	4.500 (NÃO)	**%VGV Perm Fin Líquida (% Ter)**	5,5% (67,9%)
Valor R$/m²	1.618	**VAR (%VGV)**	000 (0,0%)

Custo Construção (%VGV)	72.330 (41,5%)	**Indireto Unit.**	19.235
Prazo da Obra (meses)	23	**Torre Unit.**	60.282
Custo Total Unit. (LPU):	112.664 (94)	**Infra Unit.**	12.380
Início de Obra	abr-26	**Fundação Unit.**	6.909

	Preço Nominal Unit.	271.451	**VSO**	36
[2]	**Preço Raso Unit.**	248.101	**Referência**	Vision
	Avaliação Unit.	269.717	**Renda (% em RET 1%)**	4.886 (0,0%)



LI (Régua):	**20,7% (20,0%)**	**Margem Bruta Econômica:**	40,3%
LI Marginal:	21,6%	**Margem Rasa Econômica:**	33,9%
Margem Bruta REF:	44,0%	**Margem Contribuição Econômica:**	28,7%
Margem Rasa REF:	**38,7%**	**Exposição (% VGV):**	17.174 (10,0%)
TIR:	108,1%	**VGV Total:**	**174.272**
Payback Contingente (21 m) :	**20 m/ (-1 m)**	**Ger. Caixa 12 meses (R$):**	(14.492)
Payback Consolidado:	20	**Ger. Caixa 24 meses (R$):**	15.856

Destaques

[1] Geral:
Todas as observações do slide anterior do cenário real, são aplicáveis para este slide do cenário aprovação. A única diferença entre os cenários, é a folga de início da regra de ouro (aprovação) X cenário do PCP 168 (real), impactando o prazo de PSOL e por consequência uma redução no preço de venda no cenário aprovação.

[2] Preço de venda
Adotando a regra de ouro com folga de início de 6 meses (cenário real 9 meses), gerando um PSOL de 28 meses (cenário aprovação 31 meses);.

One Page – Panorama Santo André – Real

[1]

Cidade	Santo André	Mancha de demanda	SPRM - ABCD - ABCD
Regional	SPRM	Cluster MPR	2 - Amarelo
Cenário de Aprovação	Real	Tipo de Aprovação	Consolidado
Fase Anterior	N/A		
Tipo de Comitê	Escritura e Lançamento	Versão da VF	Versão 1.0: Set

Unidades (Fases)	642 (1)	CA Máx | Proj	4,5 | 2,4
Unidades com Vaga (%)	250 (39%)	Escritura | Lançamento	set/25 | out/25
Unidades com Varandas (%)	306 (47,7%)	Tipologia	F2E Plus - CDW

[2]

Valor Líquido do Terreno (% VGV	14.000 (7,9%)	Un. Perm. Fís (% Ter)	0 (0,0%)
Cash (Correção)	4.500 (NÃO)	%VGV Perm Fin Líquida (% Ter)	5,4% (67,9%)
Valor R$/m²	1.664	VAR (%VGV)	000 (0,0%)

[3]

Custo Construção (%VGV)	72.330 (40,9%)	Indireto Unit.	19.235
Prazo da Obra (meses)	23	Torre Unit.	60.282
Custo Total Unit. (LPU):	112.664 (94)	Infra Unit.	12.380
Início de Obra	jul-26	Fundação Unit.	6.909

[4]

Preço Nominal Unit.	275.377	VSO	36
Preço Raso Unit.	252.026	Referência	Vision
Avaliação Unit.	269.717	Renda (% em RET 1%)	4.886 (0,0%)

Fase de Lançamento - Uso exclusivo para o Ciclo Financeiro		Preço Raso Inf. Médio Unit.	257.033
Preço Inf. Médio Unit.	280.828	Margem Bruta REF (%)	44,2%
Custo Inf. Médio Unit.	156.769	Margem Rasa REF (%)	39,0%



LI (Régua):	21,3% (20,0%)	Margem Bruta Econômica:	40,7%
LI Marginal:	22,2%	Margem Rasa Econômica:	34,3%
Margem Bruta REF:	44,2%	Margem Contribuição Econômi	29,1%
Margem Rasa REF:	39,0%	Exposição (% VGV):	13.648 (7,8%)
TIR:	109,6%	VGV Total:	176.792
Payback Contingente (21 m) :	21 m/ (0 m)	Ger. Caixa 12 meses (R$):	(11.480)
Payback Consolidado:	21	Ger. Caixa 24 meses (R$):	9.818

Destaques

[1] Projeto: O Terreno possui área de 8.654 m², localizado em Santo André. O projeto é composto por 1 condomínio em fase única, 2 torres de 16pp e 18pp, tipologia F2E CDW (T+18), 214 vagas de carro (exigência de 1/3), e 306 unidades com varandas (47%). Projeto conta com a implantação de edifício garagem pré-moldado, e trouxe como benefício o aumento de 38% no número de unidades, atendendo a exigência de 1/3 de vagas.
Atingimos um CA de 2,42X contra um CA máx de 4,5X. A Legislação limita empreendimentos a T+21; chegamos a estudar as torre neste gabarito porém ficou ineficiente.

[2] Condição Comercial
- R$ 14,00MM (R$1.619/m² e R$668/CA atingido) em preço total certo, fixo e irreajustável, sendo 4.5MM (32%) cash e saldo de 9.5MM (68%) atrelado ao fluxo da perm.financ. apurado em 5,37% do VGV até o atingimento do Preço Total.
- Cash em 6x vinculado a escritura, com sinal de R$ 200K garantido em AF pago após a superação da primeira tranche (180dd) das resolutivas – pago em dez/24
- Seguro garantia referente ao valor da permuta financeira.

OBS: Para efetivação da escritura aguardaremos a aprovação do projeto pela municipalidade.

[3] Custo: Custo total de R$ 112.664/uh.
O edifício garagem, com custo de R$ 7.118/uh, viabilizou o acesso de pedestres da rua ao pavimento térreo das torres que possuem grande desnível e utilizando o mesmo elevador e caixa de escada compartilhados. Essa solução também permitiu redução de aproximadamente 70% nas contenções.

[4] Preço de venda:
Adotando o PCP 168, gerando um PSOL de 31 meses; 18 meses de venda com VSO de 36 conforme regra de ouro.
Adotamos na precificação os valores oficiais de avaliação CEF, porém acreditamos em potencial de melhora através de contestação. Atributo varanda avaliado em R$ 9,3K e vaga em R$27,8K.

- Pareceres
- Análise da Mancha e Implantação
- Prospecção
- Operações
- Inteligência de Mercado
- Financeiro

Faróis Pareceres – Panorama Santo André

Área	Riscos Associados	Parecer	Criticidade
Jurídico	Em que pese tenha constado apontamento em nome da VENDEDORA, foi apresentada comprovação patrimonial muito superior a ação localizada, motivo pelo qual concordamos com o prosseguimento da aquisição, não existindo óbices e/ou elementos jurídicos intransponíveis capazes de impedir ou colocar em risco a aquisição. Quanto ao registro da incorporação, aguardamos lavrar a escritura de venda e compra, projeto aprovado e dispensa do Graprohab.	Ok	
Legalização	Sem riscos associados. Emitido o Termo de Compromisso Ambiental e aguardando a emissão do alvará de construção.	Ok	
Produto	Sem riscos associados	OK	
GETEC	Sem riscos associados	Ok	
Logística	Sem riscos associados. Porém conforme alinhado com a regional, definiu-se que a obra está conduzida como um projeto de módulo único. Dessa forma, a primeira torre a ser concretada será a torre dos fundos (módulo 2). Caso essa sequência de execução não seja viável, deverá ser previsto o uso de uma grua para este empreendimento.	Ok	
Contratação	Laudo de engenharia: Protocolo de Análise Definitiva em 17/09, desafio de recebermos esse retorno do 1º ofício até final de setembro, sla padrão são 20 dias. Risco: Pendente - Emissão do LAE. Jurídico: Pendente - Aguardando emissão do RI - previsão final de outubro.	Ok, com ressalvas	
Inteligência de mercado	IM avalia o preço Vision como factível	Ok	
Comercial/Ciclo	O Ciclo validou o preço e o VSO como viáveis. O projeto está localizado em uma região onde já tivemos lançamentos bem-sucedidos e que atualmente apresenta escassez de concorrentes, o que nos deixa confortáveis. Como ponto de atenção, destacamos a avaliação bem abaixo do preço nominal sugerido, fator que deve ser acompanhado de perto até o lançamento.	Ok	
Estudos Econômicos	Sem riscos associados.	Ok	

Pareceres

Análise da Mancha e Implantação

Prospecção

Operações

Inteligência de Mercado

Financeiro

Macrolocalização – Rua Adriático, 541 – Jd. do Estádio

Mancha de Demanda

MANCHAS DE DEMANDA
• SAE – Santo André + São Caetano

Landbank

1. Panorama Sto. André
2. Cunha

Cluster MPR – (Comitê)
Cluster 2 - Amarelo

Região
Capital

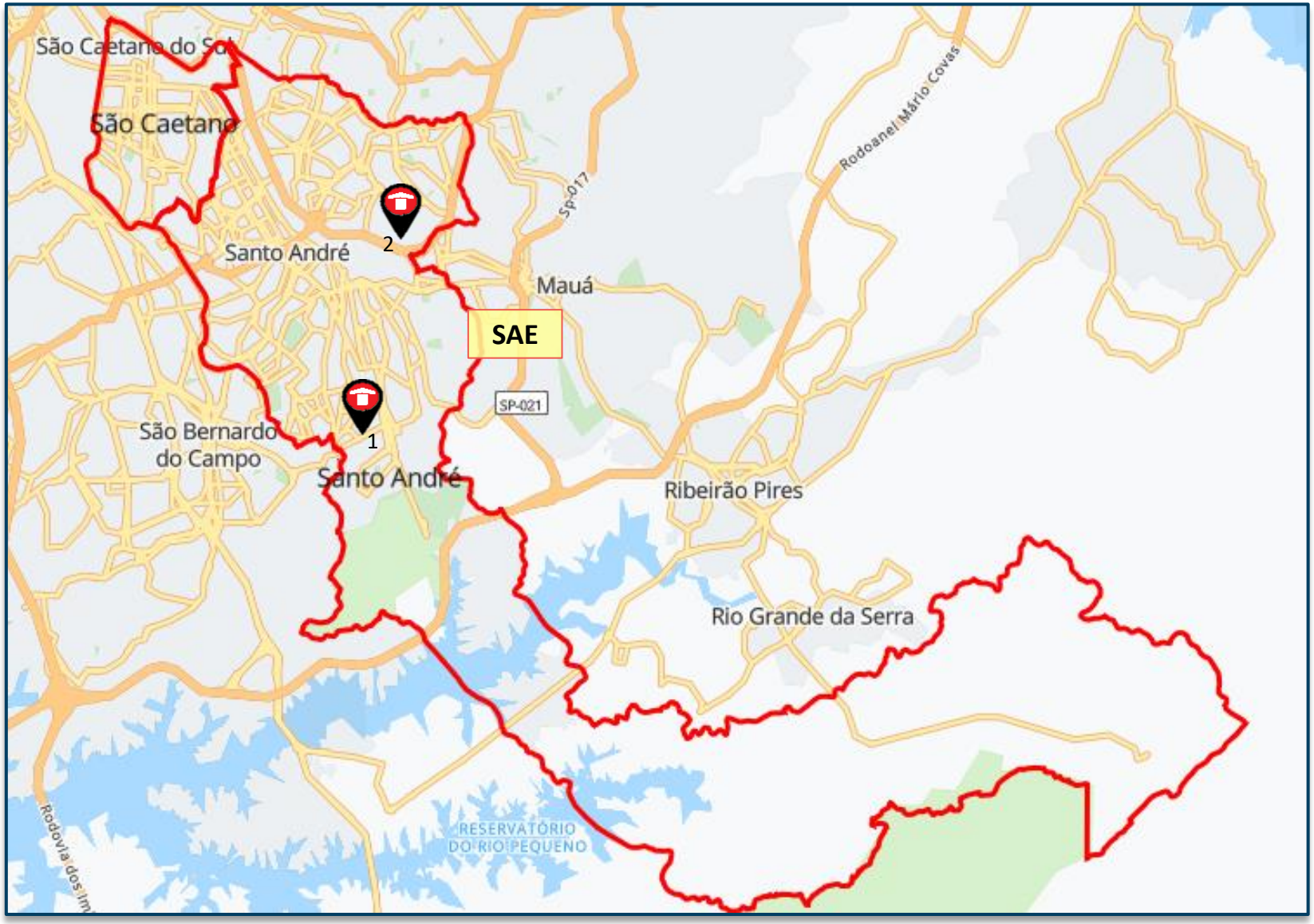

Lançados *LandBank* *Comitê*

PRODUTO

Empreendimento Panorama Santo André (Adriático)
Escritura e Lançamento

Informações Gerais – Condomínio Único		
Terreno	**Área terreno real**	8.654,00m²
	Menor poligonal	8.654,00m²
	App/fna	Não/Não
	Área de recuo de afastamento – 3m (Diretriz Urbanística)	Sim | 242,56m²
	Área liquida	8.411,44m²
	Zoneamento	ZEIS B
	Ca máximo	4,50
	Ca projetado	2,42
	Gabarito máximo	T+21
Geral	**Total uh**	642
	Total de vagas exigidas	1/3 vagas + 1% PCD + 1/80 moto delivery + 1/35 vaga visitantes + 1 vaga/torre carga/descarga
	Total de vagas projetadas	250, sendo: 218 (214 vagas comuns + 4 PCD - Edifício Garagem) + 2 carga/descarga visitantes +18 vagas comuns visitantes + 2 motos + 10 motos delivery | 39%
Tipologia	**Tipologia**	SP-0200-LN-CD10-CE1B-CDW
	Gabarito	T+18
	Lâmina	01 x 18PP 01 X 16PP
	Área privativa	31,61m² e 31,38m²
	Varanda	Sim | 306 uh (47%)
	Garden	Não
Condomínio	**Unidade pcd**	20 | térreo (3%)
	Unidade lazer|técnica	03 | 01
	Torres	02
	Fase	Única
Lazer	**Lazer interno**	01 e 03-Salão de festas gourmet, 02-Espaço Office
	Lazer externo	04 e 05-Praça de chegada, 06-Playpet, 07-Churrasqueira gourmet com banheiro e previsão de geladeira, 08-Praça dos sabores, 09-Play Baby, 10-Praça de jogos, 11-Play Kids, 12-Multipla estação, 13-Espaço de convivência, 14-Espaço cultivo.

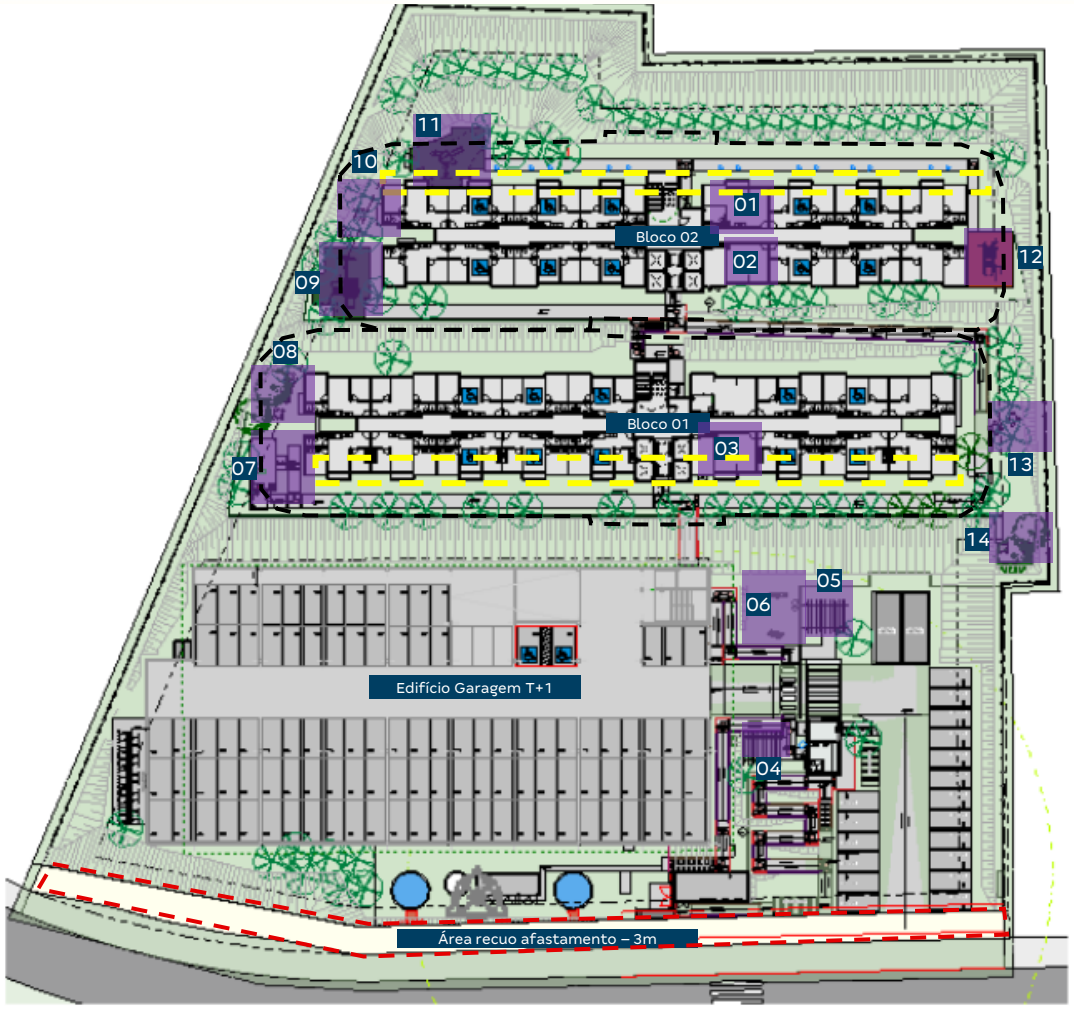

Rua Adriático

Varanda 80cm profundidade

Após alguns estudos de Getec para avaliar a melhor solução de estrutura e do FO com menor custo para o edifício garagem, a solução mantida foi com T+1, solução original do anteprojeto, economicamente mais rentável.

PRODUTO

Empreendimento Panorama Santo André (Adriático)
Escritura e Lançamento

	Descrição	Criticidade	Observação
Usabilidade	**Acesso Empreendimento**		Rampas + escada externa, caixa de elevador + escadas internas do edifício garagem e passarela
	Percurso do pedestre até torre		Desnível em torno de 12,5m do acesso até o último bloco, através de passarela do edifício garagem ao nível do Bloco 1 e acesso ao Bloco 2 através de fruição do Bloco 01 + rampas e escada
Diferencial produto	**Faixa de renda**	2	
	Prime	Sim	
	Supercondomínio	Não	
	Atributos Infra	Não	
	Atributos Torre	Sim	Varanda em uma face de cada torre
	Edifício Garagem	Sim	T+1, sendo: 108 vagas comuns + 2 vagas PCD no térreo e 106 vagas comuns + 2 vagas PCD na cobertura, totalizando 218 vagas

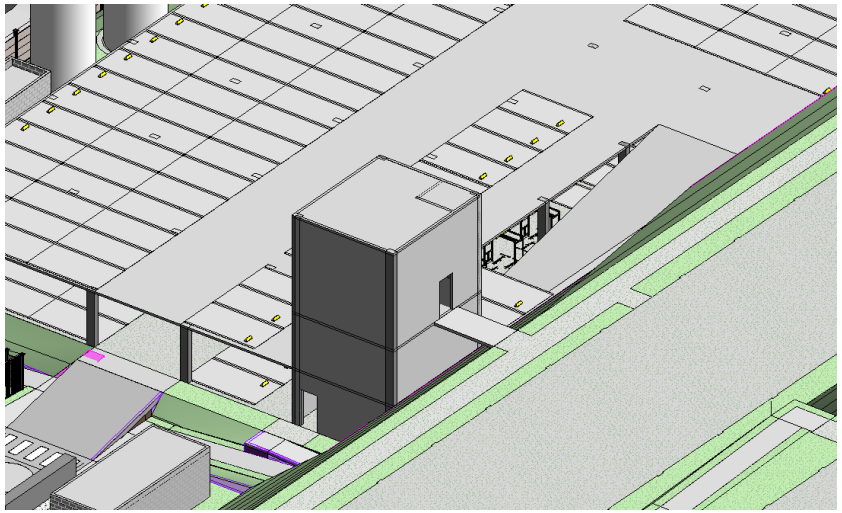

Acesso

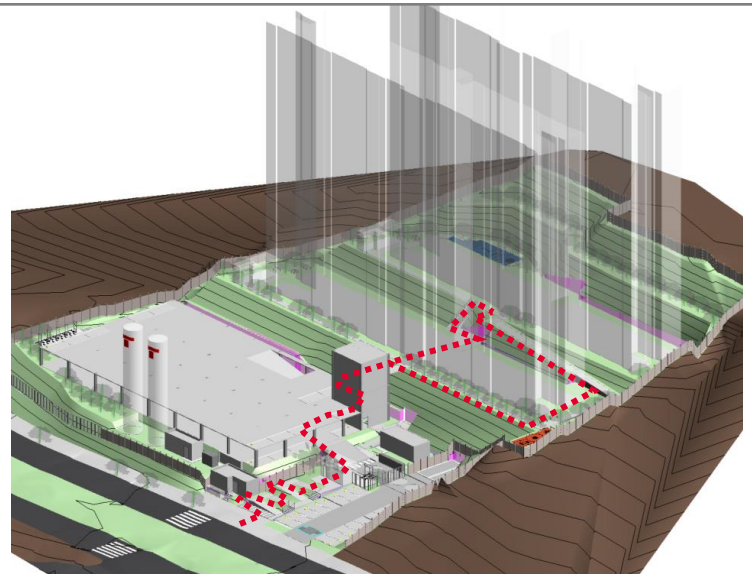

Percurso

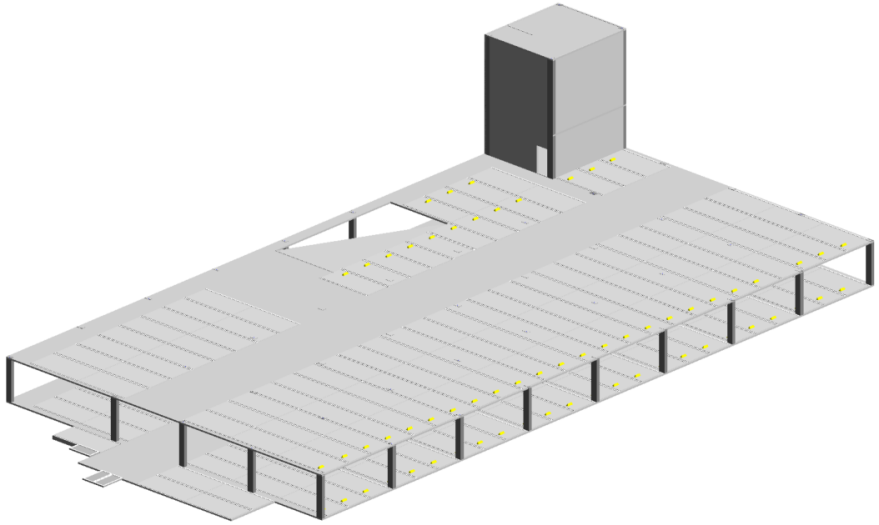

Edifício Garagem

PRODUTO

Empreendimento Panorama Santo André (Adriático)
Escritura e Lançamento

Fase Única: 642 uh- 250 vagas, sendo: 218 (214 vagas comuns + 4 PCD - Edifício Garagem) + 2 carga/descarga visitantes +18 vagas comuns visitantes + 2 motos + 10 motos delivery				
Módulo	**Blocos**	**UH**	**Vagas**	**Parecer**
Módulo 01	01 Bloco (T+18)	340 Uh	218 (214 vagas comuns + 4 PCD - Edifício Garagem) + 2 carga/descarga visitantes +6 vagas comuns visitantes + 2 motos + 10 motos delivery	Dos Lazeres, estão contemplados no módulo 01 as Praças de Chegada, Play Pet, Churrasqueira gourmet com banheiro e previsão de geladeira, Praça dos Sabores Demais lazeres que não estão contemplados neste módulo, necessário inclusão dessa informação no RI e material de vendas.
Módulo 02	01 Bloco (T+18)	302 UH	12 vagas comuns visitantes	Dos Lazeres, estão contemplados no módulo 02 o Play Baby, Praça de Jogos, Play Kids, Multipla estação, Espaço de convivência, Praça do Cultivo

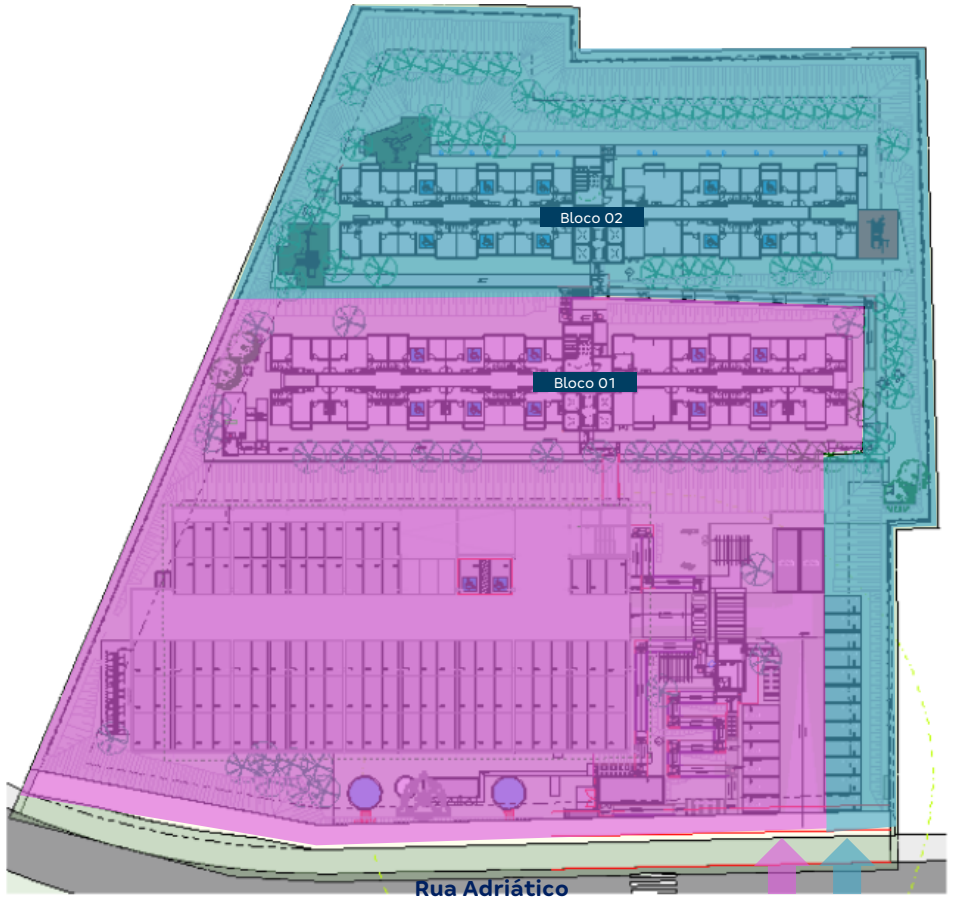

Pareceres

Análise da Mancha e Implantação

Prospecção

Operações

Inteligência de Mercado

Financeiro

Condições do negócio

VALOR DO NEGÓCIO

- R$ 14.000.000,00 (1.618 R$/m² e R$ 668/CA atingido) em preço total certo, fixo e irreajustável.

CONDIÇÃO

- Fração Cash/Permuta: 32,14% em dinheiro e 67,86% permuta financeira

FORMA DE PAGAMENTO

- Parcelas em cash (4,5MM)
  - R$ 200.000,00, pós resolutivas, contra Alienação Fiduciária; Pago em dez/24
  - R$ 4,3MM em 6 mensais, sendo a 1ª no ato da escritura e as demais mensalmente sucessivamente;
- Parcela em permuta Financeira (R$ 9,5MM)
  - Conforme VGV atual estimado, será definido em escritura o percentual aferido de 5,37% incidente sobre a receita das vendas do projeto atual; OBS: o ctr previa um repasse de 8,5% considerando a versão inicial do projeto com 406 unidades, até o atingimento do Preço total certo, fixo e irreajustável.

GARANTIAS

- Garantia ao pagamento: Seguro Garantia da Permuta Financeira (0,35%).

ESCRITURA E POSSE

- Concomitante à superação integral das resolutivas do contrato.

CORRETAGEM

- 6% sobre o valor total pagos em 6 parcelas, iniciando 30 dias após ECV

PRAZOS:

- Primeira tranche: 180 dias (4 meses + 2 meses) **SUPERADO**
- Segunda tranche: 510 dias (14 meses + 3 meses) (15/02/26)

Condições do Negócio – Resolutivas

I. Prazo de até 180 (cento e oitenta) dias contados da data de assinatura deste contrato: até 13/11/2024

(i) a existência de ação de desapropriação e/ou declaração de utilidade pública que objetive os Imóveis ou parte deles; **SUPERADO**
(ii) a existência de cadastro como imóvel tombado e/ou em processo de tombamento e/ou em áreas envoltórias, no IPHAN, CONDEPHAAT ou CONPRESP, que impossibilitem a adequada consecução do Empreendimento; **SUPERADO**
(iii) a não apresentação da documentação e/ou esclarecimentos indicados nas Cláusulas 3.1.1, 3.2, 3.2.1 e 3.4 e no ANEXO I pela VENDEDORA no prazo ali indicado ou a existência de qualquer apontamento nos documentos e certidões forenses que objetive, onere e/ou possa trazer vício à cadeia dominial do Imóvel e/ou possam reduzir a VENDEDORA ao estado de insolvência civil, ou que traga insegurança jurídica na operação objeto deste instrumento, a exclusivo critério da COMPRADORA; **SUPERADO**
(iiv) a impossibilidade da realização do estudo de passivo ambiental ou a existência de qualquer tipo de contaminação do solo, subsolo e águas do Imóvel, bem como qualquer outro tipo de passivo ambiental e/ou impossibilidade de remoção de árvores que comprometam o Empreendimento que a COMPRADORA pretende desenvolver no Imóvel; **SUPERADO**
(v) a existência de óbice à consecução, nos Imóveis, do Empreendimento almejado pela COMPRADORA no Imóvel; **SUPERADO**
(vi) a não viabilidade das redes de água e esgoto existentes no local, que sejam tidas como insuficientes a garantir a vazão necessária às unidades autônomas que comporão o empreendimento pretendido; **SUPERADO**
(vii) a não viabilidade de rede elétrica para abastecimento do futuro Empreendimento; **SUPERADO**
(viii) a não viabilidade de execução da drenagem ou não permissão de passagem em terreno de terceiros; **SUPERADO**
(ix) caso o gabarito de altura pretendido para o Empreendimento pretendido não seja aprovado no DECEA (Departamento de Controle do Espaço Aéreo) e COMAER (Comando da Aeronáutica); **SUPERADO**
(x) caso o presente negócio não seja aprovado do comitê de investimentos da COMPRADORA; **SUPERADO**
(xi) caso a VENDEDORA não apresente os instrumentos relativos ao Contrato de Locação e ao BTS (cópia dos contratos acompanhadas dos respectivos distratos), conforme previsto na Cláusula 1.5, supra. **SUPERADO**

Condições do Negócio – Resolutivas

II – Em até 14 (quatorze) meses a contar da superação das condições descritas no item "I", supra, prorrogáveis automaticamente por mais 90 (noventa) dias, a critério da COMPRADORA: até 15/02/26

(xii) caso as Partes não logrem promover eventuais regularizações relativas ao Imóvel, necessárias para a consecução do Empreendimento pretendido;
(xiii) caso seja constatada pela COMPRADORA a existência de terceiros ocupantes no Imóvel, existindo pessoas e coisas, que impeçam a transferência da posse para a COMPRADORA de forma inteiramente livre e desimpedida, nos termos previstos no presente instrumento; **livre**
(xiv) o não aperfeiçoamento de quaisquer das condições resolutivas, relativas ao terreno e ao Empreendimento, abaixo relacionadas:

(a) análise da viabilidade técnica e financeira do Empreendimento; **SUPERADO**
(b) análise da viabilidade comercial do Empreendimento; **SUPERADO**
(c) verificação da manutenção da segurança jurídica, contemplando a análise das certidões da VENDEDORA e do Imóvel, nos termos da Cláusula 3.5, supra. **SUPERADO**

(xv) a não aprovação nos termos da legislação vigente do projeto do Empreendimento pela Prefeitura Municipal e demais órgãos competentes, necessários para viabilizar sua edificação, mediante a obtenção de todas as licenças necessárias para tal fim e/ou exigências pela Prefeitura Municipal de obrigações adicionais não contempladas no projeto apresentado e/ou de contrapartida que acarrete a inviabilidade financeira do Empreendimento pretendido pela COMPRADORA; **PENDENTE – EXPECTATIVA 30/09/25**
(xvi) a inviabilidade de contratação de financiamento pela instituição financeira para construção do Empreendimento, consoante os termos e condições do Programa do Governo Federal Minha Casa Minha Vida ou qualquer outro que venha a substituí-lo; e **PENDENTE – EXPECTATIVA 30/09/25**
(xvii) a não comprovação, pela VENDEDORA, do cancelamento/arquivamento do processo mencionado na Cláusula 1.4, supra, em trâmite perante a Prefeitura Municipal, conforme previsto na Cláusula 1.4.1, supra. **SUPERADO**

Pareceres

Análise da Mancha e Implantação

Prospecção

Operações

Inteligência de Mercado

Financeiro

Custo de Construção

	ADRIATICO R00	ADRIÁTICO CEN04 | REV02	DUO VILA MATILDE LVS
Torres	2	2	2
Unidades Construídas	646	646	644
Unidades Vendidas	642	642	634
Cidade	Santo André - SP	Santo André - SP	São Paulo - SP
Produto / Selo	F2EPlus - V0200 CDW	F2E - V0200 CDW	SP-F2E Plus-CDW
Tipologia	1 Torre | T+18 | 16PP	1 Torre | T+18 | 16PP	2 Torres | 14PP | T+22
Tipologia	1 Torre | T+18 | 18PP	1 Torre | T+18 | 18PP	
Atributos	306 Varandas		
Projeto Infra	EP	AP	
Projeto Torre	EP	AP	
Mês Base	setembro-25	novembro-24	julho-25
Incc	1.210,471	1.149,170	
LVS	julho-25	setembro-24	
Indiretos	julho-25	setembro-24	
Base de Preço	LPU 94	LPU 84	
Takt	2x2	2x2	
Prazo (mês)	23	22	23
CUSTO TOTAL I	R$ / UND R$ 103.511	R$ / UND R$ 97.555	R$ / UND R$ 110.659
Indireto	R$ 19.235	R$ 18.075	R$ 17.784
Torre	R$ 60.282	R$ 53.032	R$ 71.737
Infra	R$ 12.380	R$ 14.271	R$ 12.569
Fundação	R$ 6.909	R$ 8.271	R$ 7.138
EEE			
ETE			
Contenção	R$ 1.987	R$ 1.205	R$ 674
Terraplenagem	R$ 2.719	R$ 2.700	R$ 757
CUSTO TOTAL II	R$ 2.034	R$ 3.947	R$ 549
Urbanização	R$ 105	R$ 201	
Drenagem		R$ 183	
Extensão de Rede Elétrica	R$ 234	R$ 187	
Extensão de Rede Hidráulica	R$ 1.695	R$ 3.376	R$ 549
CUSTO TOTAL III			
Incorridos			
CUSTO TOTAL IV	R$ 7.118	R$ 7.055	
Ed. Garagem	R$ 7.118	R$ 7.055	
CUSTO TOTAL IV		R$ 5.414	
Atualização por INCC		R$ 5.414	
CUSTO TOTAL I+II	R$ 105.545	R$ 101.502	R$ 111.208
CUSTO TOTAL I AO IV	R$ 112.664	R$ 113.972	R$ 111.208

Custo de Construção

	ADRIATICO R00	ADRIÁTICO CEN04 | REV02	
Torres	2	2	
Unidades Construídas	646	646	
Unidades Vendidas	642	642	
Condomínios (qta.)	1	1	
Cidade	Santo André - SP	Santo André - SP	
Produto / Selo	F2EPlus - V0200 CDW	F2E - V0200 CDW	
Tipologia	1 Torre | T+18 | 16PP	1 Torre | T+18 | 16PP	
Tipologia	1 Torre | T+18 | 18PP	1 Torre | T+18 | 18PP	
Atributos	306 Varandas		
Projeto Infra	EP	AP	
Projeto Torre	EP	AP	
Mês Base	setembro-25	novembro-24	
Incc	1210,471	1149,170	
LVS	julho-25	setembro-24	
Indiretos	julho-25	setembro-24	
Base de Preço	LPU 94	LPU 84	
Takt	2x2	2x2	
Prazo (mês)	23	22	
CUSTO TOTAL I	R$ / UND R$ 103.511	R$ / UND R$ 97.555	DIF R$ 5.957
Indireto	R$ 19.235	R$ 18.075	R$ 1.160
Torre	R$ 60.282	R$ 53.032	R$ 7.250
Infra	R$ 12.380	R$ 14.271	-R$ 1.891
Fundação	R$ 6.909	R$ 8.271	-R$ 1.363
EEE	R$ 0	R$ 0	R$ 0
ETE	R$ 0	R$ 0	R$ 0
Contenção	R$ 1.987	R$ 1.205	R$ 782
Terraplenagem	R$ 2.719	R$ 2.700	R$ 19
CUSTO TOTAL II	R$ 2.034	R$ 3.947	-R$ 1.913
Urbanização	R$ 105	R$ 201	-R$ 96
Drenagem	R$ 0	R$ 183	-R$ 183
Extensão de Rede Elétrica	R$ 234	R$ 187	R$ 47
Extensão de Rede Hidráulica	R$ 1.695	R$ 3.376	-R$ 1.681
CUSTO TOTAL III	R$ 0	R$ 0	
Incorridos	R$ 0	R$ 0	R$ 0
CUSTO TOTAL IV	R$ 7.118	R$ 7.055	
Ed. Garagem	R$ 7.118	R$ 7.055	R$ 63
CUSTO TOTAL IV	R$ 0	R$ 5.414	
Atualização por INCC	R$ 0	R$ 5.414	-R$ 5.414
CUSTO TOTAL	R$ 112.664	R$ 113.972	-R$ 1.309

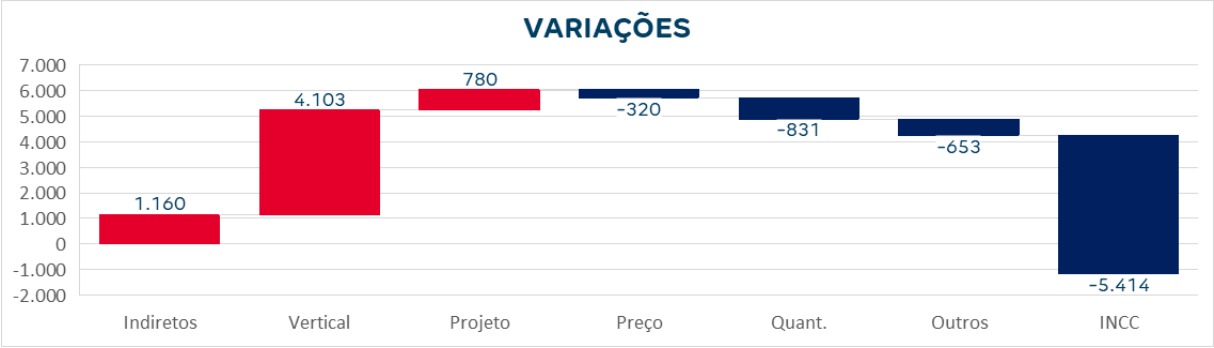

INDIRETOS
+374 | G11 Projetos
+537 | G13 Pessoal Permanente
+489 | G19 Caçambas

VERTICAL
+4.103 | Retroalimentação (Dissídio + QLP + Step)

PROJETO
-420 | Anexos (câmera transformadora)
-305 | Reservatório Metálico
+256 | Esquadria de Ferro (infra)
+123 | Tanque Pulmão
+782 | Contenção
+710 | Estrutura Torre
+1.137 | Varanda
- 1.681 | Extensão de Rede (Cotação Engekon)
+1.494 | Fundação (lajão)
(+601 | Trincheira +525 | Concreto +115 | Execução do Piso 190 | Terraplenagem)
-2.857 | Fundação (profunda)
Pré: Ø40, 50 e 60 | 339 Estacas | Comp. 19m a 23m
Param: Ø60, 70 e 80 | 502 Estacas | Comp. 16m

PREÇO
-207 | Paisagismo
+100 | Limpeza torre
+145 | Louças e metais
+237 | Esquadria de madeira
+856 | Estrutura Torre

QUANTIDADE
-440 | Bombas do Reservatório
-235 | Suporte de vigas do elevador
-156 | Sanca hall

OUTROS
-839 | Inst. Infra
+525 | Inst. Torre

INCC
-5.414 | Atualização INCC

Operações

SISTEMA DE ABASTECIMENTO DE ÁGUA
Extensão de rede de 482m no ponto de interligação, que se dará através de interligação em carga na tubulação na rede de Ø250mm em FoFo, pertencente à rede de distribuição operada pela SABESP e localizada na Av. dos Amoritas x Av. da Aclimação.

SISTEMA DE ESGOTAMENTO SANITÁRIO
Para esgotamento do empreendimento há necessidade de execução de obra de reforço de rede coletora de esgotos até um poço de visita do coletor de Ø200mm existente na Rua Adriático.

SISTEMA DE ABASTECIMENTO DE GÁS
Gás natural.

TERRENO

URBANIZAÇÃO
Considerado calçada na testada do empreendimento.

Operações

Matriz Risco Concessionária	
Água	Nível 2
Esgoto	Nível 3
Drenagem	NA
Elétrica	NA
Gás	Nível 3
Urbanização	NA

LEGENDA		
Nível	Tipo	Status
1	Com Diretriz	Conclusiva
2		Conclusiva com projeto aprovado
3		Conclusiva sem projeto aprovado
4		Não Conclusiva
5	Sem Diretriz	-
NA	-	Não aplicável

Água:
- Projeto aprovado em 09/2025.

Esgoto:
- Projeto em análise da Sabesp para aprovação.

Drenagem:
- NA.

Elétrica:
- No pedido de ligação definitiva a concessionária pode vir a cobrar reformas necessárias, caso a infraestrutura existente não seja suficiente.

Gás:
- Gás natural. Projeto em desenvolvimento para aprovação da Comgás .

Urbanização:
- Considerado calçada na testada do empreendimento.

Logística – ADRIÁTICO (RMSP)

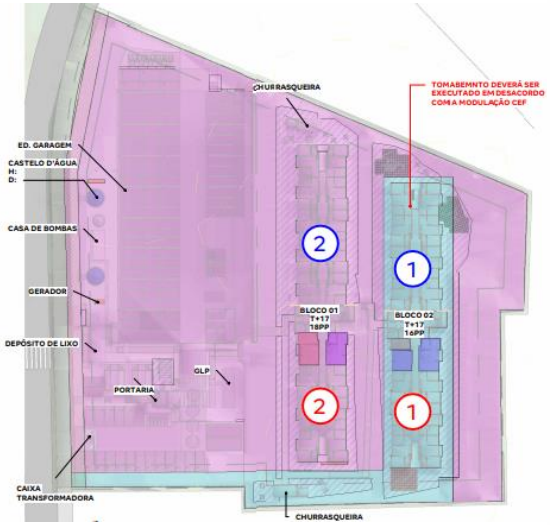

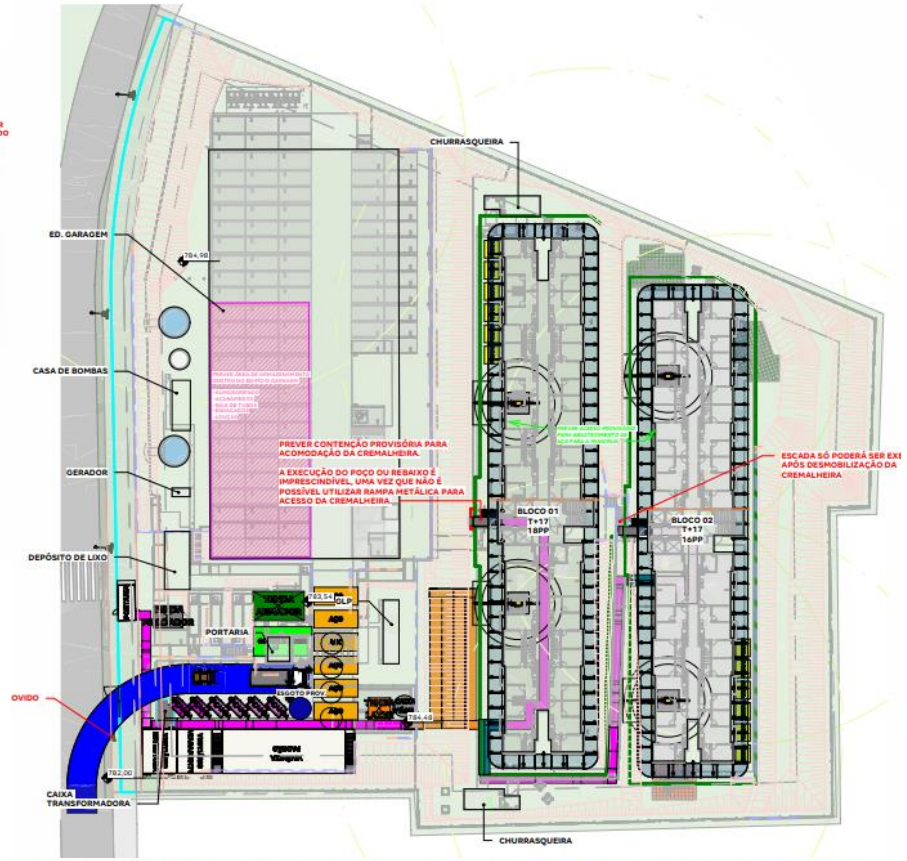

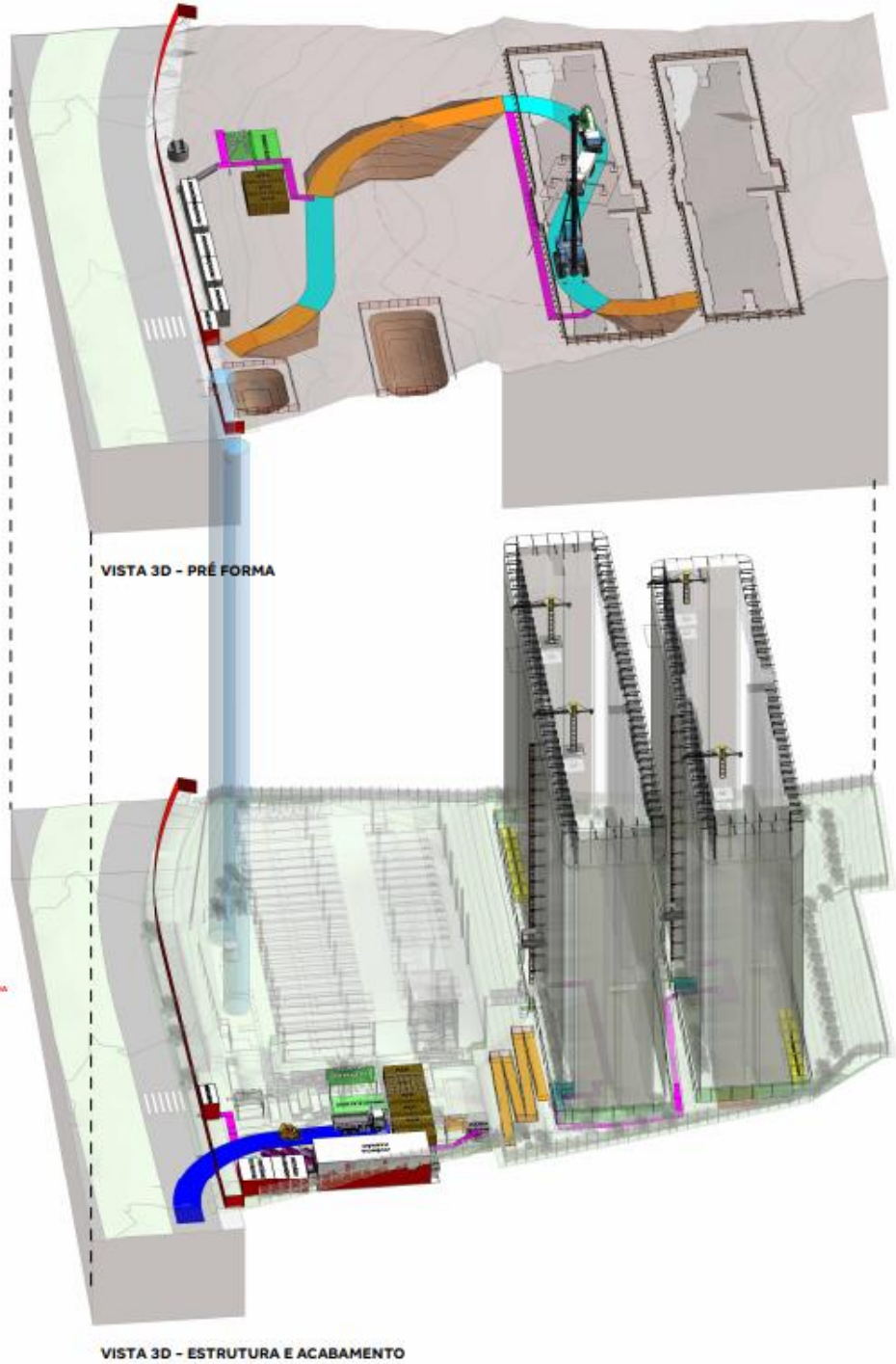

PCP 168

SP - Modular 3.0					1 JOGO =	47	Aptos/mês									
Empreendimento	Lançto.	Unidades	# jogos	Equipes de forma	Início Obra	Início Forma 1	Início Forma 2	Início Forma 3	Término Forma 1	Término Forma 2	Término Forma 3	Previsão AGI	Folga Inicio	Folga Aptidão	Folga Cliente	Carência CEF
CDW 10 | Oásis Penha	jul/25	672	2	B	22/01/26	06/07/26	06/07/26		08/02/27	08/02/27		nov/27	6,37	0,77	8,13	NC
CDW 15 | Jd dos Prados	ago/25	800	2	D	11/02/26	26/06/26	01/07/26		12/03/27	17/03/27		dez/27	6,03	5,53	8,13	NC
CDW 15 | Sobral	set/25	577	2	F	05/01/26	03/08/26	16/08/26		06/02/27	19/02/27		nov/27	3,76	-	10,17	NC
CDW 10 | Adriático	out/25	646	2	F	18/07/26	07/02/27	20/02/27		04/09/27	17/09/27		jun/28	9,23	-	4,10	NC
CDW 15 | Dália	out/25	667	2	B	23/06/26	09/02/27	09/02/27		13/09/27	13/09/27		out/28	8,85	-2,35	0,00	NC
CDW 15 | Horizonte Jaraguá	dez/25	514	2	D	03/03/26	13/03/27	18/03/27		27/08/27	01/09/27		mai/28	2,63	-	7,13	NC
CDW 15 | Vila Butantã	fev/26	793	2	A	02/07/26	27/05/27	29/05/27		08/02/28	10/02/28		out/28	4,58	-	4,00	NC
CDW 15 | Essence Butantã (Eiras Garcia)	jun/26	409	2	D	14/02/27	28/08/27	02/09/27		07/01/28	12/01/28		set/28	8,14	-	9,10	NC
CDW 10 | Essência do Campo F1	jul/26	550	2	F	12/03/27	05/09/27	18/09/27		01/03/28	14/03/28		nov/28	8,03	0,03	8,10	NC
CDW 15 | Florença	ago/26	521	2	B	02/04/27	14/09/27	14/09/27		01/03/28	01/03/28		out/28	7,69	-	10,13	NC
CDW 15 | Nilo Cairo - F1	nov/26	606	2	D	18/07/27	08/01/28	13/01/28		22/07/28	27/07/28		mar/29	8,19	-0,07	8,13	NC

Pareceres

Análise da Mancha e Implantação

Prospecção

Operações

Inteligência de Mercado

Financeiro

Demanda e Distribuição da Mancha

Potencial de Demanda			Lançados		Lançados + Landbank	
Mancha	CÓD.	Shr.	ANO	MÊS	ANO	MÊS
Santo André + São Caetano	SAE	59%	755	63	906	76

Empreendimento	Renda	Lançamento	out/25	nov/25	dez/25	jan/26	fev/26	mar/26	abr/26	mai/26	jun/26	jul/26	ago/26	set/26	out/26	nov/26	dez/26	jan/27	fev/27	mar/27	abr/27
Panorama Sto. André	**4.886**	**out-25**		**36**	**36**	**36**	**36**	**36**	**36**	**36**	**36**	**36**	**36**	**36**	**36**	**36**	**36**	**36**	**36**	**36**	**30**
Cunha	4.007	jun-26										20	20	20	20	20	20	20	20	20	20
Total de Vendas Lançados			**0**	**0**	**0**	**0**	**0**	**0**	**0**	**0**	**0**	**0**	**0**	**0**	**0**	**0**	**0**	**0**	**0**	**0**	**0**
Total de Vendas Lançados + Landbank			**0**	**36**	**36**	**36**	**36**	**36**	**36**	**36**	**36**	**56**	**56**	**56**	**56**	**56**	**56**	**56**	**56**	**56**	**50**

Parecer de I.M sobre a mancha:

O projeto analisado em comitê está em linha com o potencial teórico de demanda calculado para a mancha. (Total Lançados)

Canibalização:

Sem Risco de Canibalização

Panorama Sto. André | Mapa Concorrência

		Panorama Sto. André	Liv Santo André
		TENDA	Nazaré
	Distância Tenda (km)		2,1km
Região 1 Km	População	50.474	37.504
	Dens. Demográfica	16.142	12.015
	Renda (R$)	5.816	8.500
	Classe Social	C1 (2.7k a 4.6k)	B2 (4.6k a 8.1k)
	PEA Dia	18.576	21.609
Quantitativo	Lançamento	out/25	06/2022
	Unidades	642	200
	Estoque	642	32
	VSO	36	4
	Stockout	18	7
Qualitativo	Condomínios	1	1
	Torres	2	1
	Gabarito	T+18	T+20
	Plantas (m²)	32,5m²	39,85m²
	Tipologia	2 Dorms	2 Dorms
	Opções	Não	Não
	Varanda	Sim	Sim
	Vagas	34%	56% Vaga
	Lazer	Churrasqueira, Salão de festas, Espaço Office, Praça Chegada, Play Pet, Praça dos Sabores, Fitness, Pla Kids, Play Baby.	Tem Sacada, Churrasqueria, Fitness Center, Lavanderia, Pet Place, Piscina, Playground, Quadra, Sacada, Salão de Festas,

Farol Renda
Acima de 300
Entre 0 e 300
Abaixo de 0

Diagnóstico Concorrência

- Apesar do Liv Santo André obter baixo estoque, ele se torna uma referência da concorrência na região com preço e renda superior ao projetado pelo Vision.

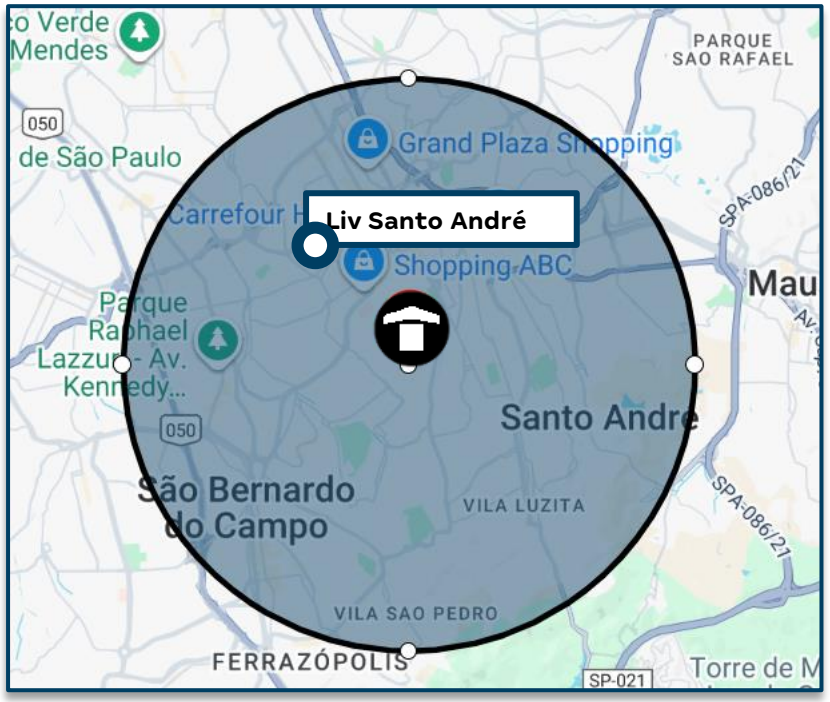

-	Panorama Sto. André					Liv Santo André					
Tipologias	Avaliação	Preço Nominal	CEF	Renda	% Unidades	Avaliação	Preço Nominal	CEF	Renda	% Unidades	Farol
UH TIPO	256.658	254.947	194.318	4.192	52%	-	-	-	-	-	-
Varanda	266.011	274.843	206.702	5.182	14%	282.000	321.000	256.800	8.500	44%	●
Carro + Varanda	291.785	305.484	226.949	5.779	17%	308.000	390.000	312.000	9.500	56%	●
Carro Coberto + Varanda	291.785	309.751	230.126	5.914	17%	-	-	-	-	-	-
Moto + Varanda	269.000	279.677	209.530	5.344	0%	-	-	-	-	-	-

Simulação de Preço

Embora haja poucas referências da concorrência na região, temos confiança no preço e no VSO proposto, sustentada pela performance do produto Vitale. Neste, alcançamos uma renda próxima à projetada para o Vision, com volume de vendas alinhado ao Panorama Sto. André, o que reforça a consistência de nossas projeções.

	Vitale - Santo André (Normalizado)				
	Avaliação	***Preço Nominal***	***Preço Raso***	***Renda***	***VSO***
HMP	238.000	260.240	228.635	4.109	16
Moto	246.100	272.781	241.365	4.347	11
Carro	259.900	295.934	262.711	5.491	13
Ponderado	**247.230**	**275.096**	**243.033**	**4.614**	**35**

	Panorama Sto. André				
	Avaliação	***Preço Nominal***	***Preço Raso***	***Renda***	***VSO***
HMP	256.658	254.947	230.801	4.192	18
Varanda	266.011	274.843	252.457	5.182	5
Carro + Varanda	291.785	305.484	282.599	5.779	6
Carro Coberto + Varanda	291.785	309.751	287.609	5.914	6
Moto + Varanda	269.000	279.677	256.591	5.344	1
Ponderado	**269.717**	**275.377**	**252.026**	**4.886**	**36**

Simulação de Preço – Cenário Real

Informações Viabilidade

Projeto:	Panorama Sto. André									
Tipo:	**UH TIPO**		**Varanda**		**Moto + Varanda**		**Carro + Varanda**		**Carro Coberto + Varanda**	
Método	**Vision**		**Vision**		**Vision**		**Vision**		**Vision**	
Avaliação	256.658		266.011		269.000		291.785		291.785	
Renda Inicial (VF)	4.192		5.182		5.344		5.779		5.914	
Renda Final*	-		-		-		-		-	
% RET1	0%		0%		0%		0%		0%	
Tipo:	**VF**	**R$**	**VF**	**R$**	**VF**	**R$**	**VF**	**R$**	**VF**	**R$**
Ato	0,64	2.695	0,77	3.988	0,75	3.988	0,95	5.488	1,07	6.333
FGTS	1,11	4.663	0,96	4.987	0,93	4.987	0,86	4.987	0,91	5.387
Financiamento	93,76%	187.276	95,30%	201.715	95,09%	204.543	95,11%	221.962	96,28%	224.739
Subsídio	110,94%	2.379	0,00%	0	0,00%	0	0,00%	0	0,00%	0
Prazo de Pró-soluto	31	31	31	31	31	31	31	31	31	31
Pró-Soluto	71,56%	33.788	71,56%	41.767	71,56%	43.073	77,06%	50.162	76,79%	51.150
Preço Raso (RS)	230.801	230.801	252.457	252.457	256.591	256.591	282.599	282.599	287.609	287.609
TCD	57,14%	24.146	42,86%	22.386	42,86%	23.086	39,29%	22.885	37,14%	22.142
VSO	18	18	5	5	1	1	6	6	6	6
Preço de Venda	**254.947**	**254.947**	**274.843**	**274.843**	**279.677**	**279.677**	**305.484**	**305.484**	**309.751**	**309.751**
Elasticidade	0,000%	0,000%	0,000%	0,000%	0,000%	0,000%	0,000%	0,000%	0,000%	0,000%
Preço de Venda Final	**254.947**	**254.947**	**274.843**	**274.843**	**279.677**	**279.677**	**305.484**	**305.484**	**309.751**	**309.751**
Preço Raso (R$)	**230.801**		**252.457**		**256.591**		**282.599**		**287.609**	
% de Raso	**90,53%**		**91,85%**		**91,75%**		**92,51%**		**92,85%**	
BP25 - Não Inflacionado	**215.022**		**-**		**-**		**-**		**-**	
BP25 - Inflacionado	**225.964**		**-**		**-**		**-**		**-**	

Análise de Preço

Informações Viabilidade

Projeto:	Panorama Sto. André
Tipo:	**Faixa 2**
Método	**Vision**
Avaliação	269.717
Renda Inicial (VF)	4.886
Renda Final*	-

Tipo:	VF	R$
Ato	0,78	3.953
FGTS	1,02	4.885
Financiamento	94,63%	201.383
Subsídio	58,06%	1.245
Prazo de Pró-soluto	31	31
Pró-Soluto	73,35%	40.559
Preço Raso (RS)	252.026	252.026
TCD	48,78%	23.351
VSO	36	36
Preço de Venda	**275.377**	**275.377**
Elasticidade	0,000%	0,000%
Preço de Venda Final	**275.377**	**275.377**
Preço Raso (R$)	**252.026**	
% de Raso	**91,52%**	
Raso Todas as Fases	**252.026**	
Nominal Todas as Fases	**275.377**	

1

Análise de Riscos	Farol IM
IM avalia o Preço Vision como **factível**.	

1) I.M está de acordo com o preço Vision, tendo em vista que, o projeto está em uma região com ótimos indicadores sociodemográficos, como renda e PEA/Dia, o mesmo também se encontra próximo de pontos de acessibilidade como terminal de ônibus, e polos de atratividade.
Projeto contará com varanda, vagas cobertas, reforçando o seu atrativo no mercado

Conforme apresentado no slide 'Panorama de Concorrência', os concorrentes da região operam em um patamar de preço e renda superior ao projetado para o Produto Tenda, evidenciando um mercado atrativo.

	Preço Real					Preço Normalizado (31m)	
	Avaliação	Preço Raso	Renda Média	VSO	PSOL	Δ PSOL	Preço Raso
Vitale Sto. André	247.230	222.429	4.614	35	16	20.604	243.033
Panorama Sto. André	269.717	252.026	4.886	36	31	-	252.026

Simulação de Preço – Cenário Aprovação

Informações Viabilidade

Projeto:	Panorama Sto. André									
Tipo:	**UH TIPO**		**Varanda**		**Moto + Varanda**		**Carro + Varanda**		**Carro Coberto + Varanda**	
Método	**Vision**		**Vision**		**Vision**		**Vision**		**Vision**	
Avaliação	256.658		266.011		269.000		291.785		291.785	
Renda Inicial (VF)	4.192		5.182		5.344		5.779		5.914	
Renda Final*	-		-		-		-		-	
% RET1	0%		0%		0%		0%		0%	
Tipo:	**VF**	**R$**	**VF**	**R$**	**VF**	**R$**	**VF**	**R$**	**VF**	**R$**
Ato	0,64	2.695	0,77	3.988	0,75	3.988	0,95	5.488	1,07	6.333
FGTS	1,11	4.663	0,96	4.987	0,93	4.987	0,86	4.987	0,91	5.387
Financiamento	94,30%	187.276	95,30%	201.715	95,09%	204.543	95,11%	221.962	96,28%	224.739
Subsídio	110,94%	2.379	0,00%	0	0,00%	0	0,00%	0	0,00%	0
Prazo de Pró-soluto	31	31	31	31	31	31	31	31	31	31
Pró-Soluto	71,56%	30.518	71,56%	37.725	71,56%	38.904	77,06%	45.307	76,79%	46.200
Preço Raso (RS)	227.531	227.531	248.415	248.415	252.423	252.423	277.745	277.745	282.659	282.659
TCD	57,14%	24.146	42,86%	22.386	42,86%	23.086	39,29%	22.885	37,14%	22.142
VSO	18	18	5	5	1	1	6	6	6	6
Preço de Venda	**251.677**	**251.677**	**270.801**	**270.801**	**275.509**	**275.509**	**300.629**	**300.629**	**304.801**	**304.801**
Elasticidade	0,000%	0,000%	0,000%	0,000%	0,000%	0,000%	0,000%	0,000%	0,000%	0,000%
Preço de Venda Final	**251.677**	**251.677**	**270.801**	**270.801**	**275.509**	**275.509**	**300.629**	**300.629**	**304.801**	**304.801**
Preço Raso (R$)	**227.531**		**248.415**		**252.423**		**277.745**		**282.659**	
% de Raso	**90,41%**		**91,73%**		**91,62%**		**92,39%**		**92,74%**	
BP25 - Não Inflacionado	**212.613**		**-**		**-**		**-**		**-**	
BP25 - Inflacionado	**223.555**		**-**		**-**		**-**		**-**	

Análise Concorrência

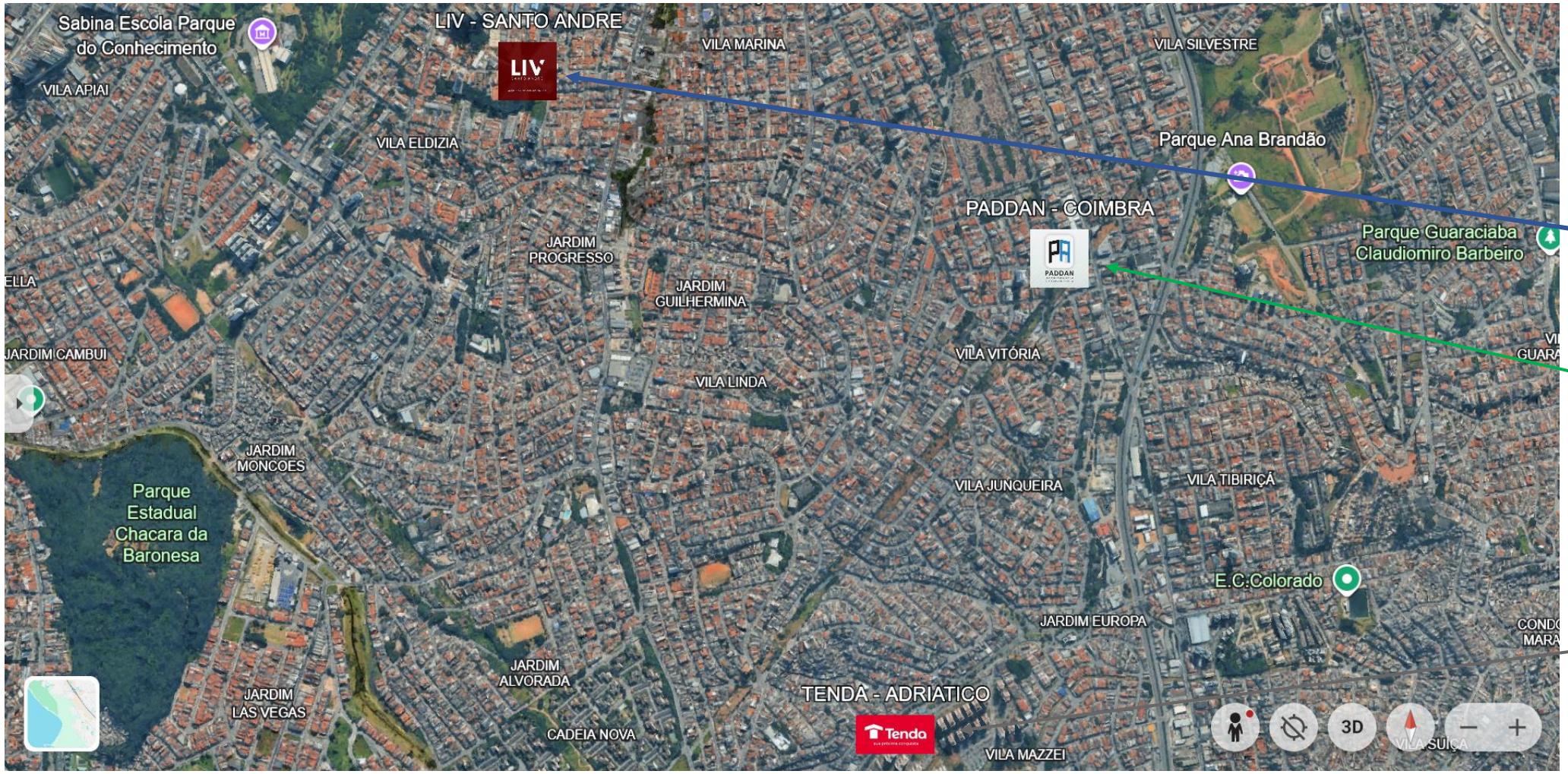

NAZARE
LIV- SANTO ANDRE
2,1K

PADAN
COIMBRA
1,5K

TENDA
Panorama Santo André

Parecer Comercial

Análise Concorrência

Concorrência 1

Incorporadora: Nazare

Inf. Produto	LIV Santo André
Data Lanç	01/07/2022
Qtde de unidade	200
Estoque	32
Renda Apartir	8.500
Tipologias	-

Preço		
39,85m² C/Varanda S/Vaga	R$	321.832,00
39,85m² C/Varanda C/Vaga	R$	392.469,82
-	-	
-	-	
-	-	

Fluxo	
Ato	20% Valor do Imovel
30/60/90	-
Prazo Pró-Soluto	12
% Pró-Soluto	30%
Prazo Intermediaria	-
% Intermediaria	-
ITBI/TCD	-
% Parcela TCD	-
Correção	-

Concorrência 2

Incorporadora: Paddan

Inf. Produto	Coimbra
Data Lanç	01/12/2025
Qtde de unidade	200
Estoque	200
Renda Apartir	-
Tipologias	-

Breve Lançamento

Preço	
-	-
-	-
-	-
-	-
-	-

Fluxo	
Ato	-
30/60/90	-
Prazo Pró-Soluto	-
% Pró-Soluto	-
Prazo Intermediaria	-
% Intermediaria	-
ITBI/TCD	-
% Parcela TCD	-
Correção	-

Parecer Ciclo

O Ciclo validou o **preço** e o **VSO** como viáveis.
O projeto está localizado em uma região onde já tivemos lançamentos bem-sucedidos e que atualmente apresenta **escassez de concorrentes**, o que nos deixa confortáveis.
Como ponto de atenção, destacamos a **avaliação bem abaixo do preço nominal sugerido**, fator que deve ser acompanhado de perto até o lançamento.

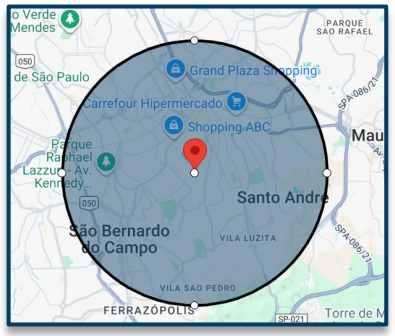

-	Panorama Sto. André					Liv Santo André					
Tipologias	Avaliação	Preço Nominal	CEF	Renda	% Unidades	Avaliação	Preço Nominal	CEF	Renda	% Unidades	Farol
UH TIPO	256.658	254.947	194.318	4.192	52%	-	-	-	-	-	-
Varanda	266.011	274.843	206.702	5.182	14%	282.000	321.000	256.800	8.500	44%	●
Carro + Varanda	291.785	305.484	226.949	5.779	17%	308.000	390.000	312.000	9.500	56%	●
Carro Coberto + Varanda	291.785	309.751	230.126	5.914	17%	-	-	-	-	-	-
Moto + Varanda	269.000	279.677	209.530	5.344	0%	-	-	-	-	-	-

- Pareceres
- Análise da Mancha e Implantação
- Prospecção
- Operações
- Inteligência de Mercado
- Financeiro

Informações Financeiras – Resumo

PANORAMA SANTO ANDRÉ – SPRM – Região Metropolitana > 100mil SP

Datas e Prazos

	Compra	Lançamento	Início Obra	Término Obra	LÇTO até IO	IO até TO	Chaves	LÇTO até Chaves
Consolidado	jun-24							
SEM VAGA SEM VARANDA		out-25	abr-26	mar-28	6 meses	23 meses	out-28	36 meses
SEM VAGA COM VARANDA		out-25	abr-26	mar-28	6 meses	23 meses	out-28	36 meses
RRO DESCOBERTO E VARANDA		out-25	abr-26	mar-28	6 meses	23 meses	out-28	36 meses
CARRO COBERTO E VARANDA		out-25	abr-26	mar-28	6 meses	23 meses	out-28	36 meses
VAGA MOTO COM VARANDA		out-25	abr-26	mar-28	6 meses	23 meses	out-28	36 meses

Terreno e Incorridos

TOTAL (R$ + Perm.):	14,00 MM	**Incorrido Terreno:**	0,20 MM	**Área do Terreno (100%):**	8.654 m²
Cash:	4,50 MM	**Nº de Parcelas Cash :**	7	**Custo de terreno m²:**	1.617,7
Permuta Financeira:	9,50 MM (5,45%)			**VaR 25 (R$ mil):**	0
Permuta Física:	0,00 MM (0,00%)			**VaR 26 (R$ mil):**	0
Ato / %VGV:	0,20 MM / 0,1%			**Incorrido de Construção:**	0,43 MM

Área Líquida do Terreno:	8.654 m²
Custo de terreno m² Área Líquida:	1.617,7
Fração Terreno/Terreno + Custo Obra (%VGV):	8,0% / 49,5%
CA Máx/Proj.	4,5 / 2,4
Incorridos de Incorporação:	0,38 MM

Vendas

Fases	Nº Pavimentos	Preço Raso Unit.	Qtde	Preço Unit.	Aval. CEF	Cond. Parcela	% Pró-soluto	% TCD
SEM VAGA SEM VARANDA	T+18	227.531	336	251.677	256.658	94,3%	71,6%	57,1%
SEM VAGA COM VARANDA	T+18	248.415	90	270.801	266.011	95,3%	71,6%	42,9%
RRO DESCOBERTO E VARANDA	T+18	277.745	106	300.629	291.785	95,1%	77,1%	39,3%
CARRO COBERTO E VARANDA	T+18	282.659	108	304.801	291.785	96,3%	76,8%	37,1%
VAGA MOTO COM VARANDA	T+18	252.423	2	275.509	269.000	95,1%	71,6%	42,9%

Unidades Totais:	642	**Preço Médio:**	271.451	**Renda Média:**	4.886	**ITBI+Emol. Unit. Médio:**	5.575
Unidades Tenda:	642	**Avaliação Média:**	269.717	**Ato:**	3.829 (0,78 Salários)	**Custo do Ciclo Unit.:**	17.088
VSO:	36 Unidades	**VGV Total:**	174.271.800	**FGTS:**	4.963 (1,02 Salários)	**Preço Raso Médio:**	248.101
RET Médio:	4,0%	**VGV Tenda:**	174.271.800	**% em RET 1%:**	0%	**Adc. Tx. de Aceleração Médio:**	750

Construção

Custo Total Unit.:	112.664	**Eventuais:**	4,00%	**Área priv (m²):**	32,50	**Gape / Mês Unit.:**	11,08

Resultado

LI (R$):	**25.132.453**	**LI:**	**20,72%**	**Exposição de Caixa (R$):**	**17.174.280**	**Margem Bruta Econômica:**	**40,33%**
TIR:	**108,12%**	**LI Aprovação:**	**20,00%**	**Ger. Caixa 12 meses (R$):**	**(14.492.476)**	**Margem Bruta REF:**	**43,98%**
Exposição de Caixa:	**9,99%**	**Δ LI:**	**0,72%**	**Ger. Caixa 24 meses (R$):**	**15.856.319**	**Margem Rasa Econômica:**	**33,91%**
Payback Contingente (21 m):	**20 m/ (-1 m)**	**LI Marginal:**	**21,65%**	**Ger. Caixa Marginal (R$):**	**46.140.120**	**Margem Rasa REF:**	**38,71%**
Payback Consolidado:	**20 meses**					**Margem de Contribuição Econômica:**	**28,68%**

DRE

R$ Mil - Valores Nominais - Compra	PANORAMA SANTO ANDRÉ		SEM VAGA SEM VARANDA		SEM VAGA COM VARANDA		CARRO DESCOBERTO E VARANDA		CARRO COBERTO E VARANDA		VAGA MOTO COM VARANDA	
	Nominal	%	Nominal	%	Nominal	%	Nominal	%	Nominal	%	Nominal	%
Receita	171.865	100,0%	83.774	100,0%	23.995	100,0%	31.274	100,0%	32.265	100,0%	558	100,0%
PIS/COFINS	(3.770)	2,2%	(1.838)	2,2%	(526)	2,2%	(686)	2,2%	(708)	2,2%	(12)	2,2%
Custo Total	(100.310)	59,7%	(52.061)	63,5%	(14.033)	59,8%	(16.798)	54,9%	(17.081)	54,1%	(337)	61,7%
Custo Terreno	(14.000)	8,3%	(6.937)	8,5%	(1.962)	8,4%	(2.490)	8,1%	(2.566)	8,1%	(45)	8,2%
Custo Relacionados a Terreno	(1.406)	0,8%	(710)	0,9%	(197)	0,8%	(244)	0,8%	(250)	0,8%	(4)	0,8%
Custos de Incorporação	(2.720)	1,6%	(1.401)	1,7%	(353)	1,5%	(495)	1,6%	(439)	1,4%	(31)	5,8%
Custo de Construção	(82.184)	48,9%	(43.012)	52,5%	(11.521)	49,1%	(13.569)	44,4%	(13.825)	43,8%	(256)	46,9%
Lucro Bruto Econômico	67.785	40,3%	29.875	36,5%	9.435	40,2%	13.789	45,1%	14.476	45,9%	209	38,3%
Custo para Rateio	-	0,0%	-	0,0%	-	0,0%	-	0,0%	-	0,0%	-	0,0%
Lucro Bruto Contábil	67.785	40,3%	29.875	36,5%	9.435	40,2%	13.789	45,1%	14.476	45,9%	209	38,3%
Despesas de Selling	(15.620)	9,3%	(7.635)	9,3%	(2.185)	9,3%	(2.831)	9,3%	(2.920)	9,3%	(49)	8,9%
Contingência	(3.953)	2,4%	(1.927)	2,4%	(552)	2,4%	(719)	2,4%	(742)	2,4%	(13)	2,4%
Margem de Contribuição	48.212	28,7%	20.313	24,8%	6.699	28,5%	10.239	33,5%	10.814	34,3%	147	27,0%
IR e CSLL	(3.084)	1,8%	(1.504)	1,8%	(431)	1,8%	(561)	1,8%	(579)	1,8%	(10)	1,8%
Margem Líquida	45.128	26,8%	18.810	23,0%	6.268	26,7%	9.678	31,6%	10.235	32,4%	137	25,2%
Lucro Bruto REF Unit.	121.741	44,0%	102.959	40,1%	121.173	43,9%	149.423	48,8%	153.502	49,4%	120.236	43,6%
Lucro Raso REF Unit.	97.946	38,7%	78.335	33,7%	98.357	38,8%	126.128	44,6%	130.956	45,4%	97.811	38,6%

R$ Mil - VPL - Compra	PANORAMA SANTO ANDRÉ		SEM VAGA SEM VARANDA		SEM VAGA COM VARANDA		CARRO DESCOBERTO E VARANDA		CARRO COBERTO E VARANDA		VAGA MOTO COM VARANDA	
	VP	%	VP	%	VP	%	VP	%	VP	%	VP	%
Receitas	121.324	100,0%	58.759	100,0%	16.976	100,0%	22.222	100,0%	22.960	100,0%	407	100,0%
PIS/COFINS	(2.621)	2,2%	(1.270)	2,2%	(367)	2,2%	(480)	2,2%	(496)	2,2%	(9)	2,2%
Custos e Despesas Totais	(93.570)	77,1%	(48.036)	81,8%	(13.085)	77,1%	(15.915)	71,6%	(16.213)	70,6%	(322)	79,1%
Custo Terreno	(10.974)	9,0%	(5.469)	9,3%	(1.538)	9,1%	(1.937)	8,7%	(1.994)	8,7%	(36)	8,8%
Custo Relacionados a Terreno	(1.427)	1,2%	(722)	1,2%	(200)	1,2%	(247)	1,1%	(254)	1,1%	(4)	1,1%
Custos de Incorporação	(2.245)	1,9%	(1.153)	2,0%	(289)	1,7%	(411)	1,9%	(362)	1,6%	(30)	7,4%
Custo de Construção	(61.983)	51,1%	(32.440)	55,2%	(8.689)	51,2%	(10.234)	46,1%	(10.427)	45,4%	(193)	47,5%
Despesas de Selling	(13.356)	11,0%	(6.511)	11,1%	(1.867)	11,0%	(2.430)	10,9%	(2.501)	10,9%	(47)	11,4%
Contingência	(1.441)	1,2%	(702)	1,2%	(201)	1,2%	(262)	1,2%	(270)	1,2%	(5)	1,1%
IR e CSLL	(2.145)	1,8%	(1.039)	1,8%	(300)	1,8%	(393)	1,8%	(406)	1,8%	(7)	1,8%
Lucro Imobiliário	25.132	20,7%	9.454	16,1%	3.525	20,8%	5.827	26,2%	6.250	27,2%	76	18,8%

Comparativo BP

Comparativo dos Estudos - Consolidado	BP - 2025	Compra	Atual	Atual vs BP - 2025	Δ%
Data Estudo:	setembro-24	dezembro-24	setembro-25	12 Meses	N/A
Lançamento:	outubro-25	outubro-25	outubro-25	0 Meses	N/A
Uhs:	464	642	642	178	38,4%
Preço Nominal:	264.129	259.658	271.451	7.322	2,8%
Preço Raso:	240.606	228.935	248.101	7.495	3,1%
Preço Nominal Inflacionado:	289.727	275.921	276.826	(12.901)	-4,5%
Preço Raso Inflacionado:	263.933	243.273	253.031	(10.902)	-4,1%
Renda Média:	4.607	4.473	4.886	279	6,1%
RET Médio:	4,00%	N/A	4,00%	0,0 p.p.	0,0%
% em RET 1%:	0,00%	N/A	0,00%	0,0 p.p.	
VSO:	26	36	36	10	38,5%
ITBI/Emol. Inf (Unit)[2]:	5.177	5.204	6.361	1.184	22,9%
Avaliação:	251.577	253.089	269.717	18.140	7,2%
Prazo construção F1:	26	22	23	(3)	-11,5%
Prazo de Pró-Soluto F1:	31	27	28	(3)	-9,7%
Custo Total Inf (Unit):	170.800	162.277	156.245	(14.554)	-8,5%
Custo Construção (Unit):	103.777	108.557	112.664	8.887	8,6%
Fração de construção:	39%	42%	41,5%	2,5 p.p.	6,4%
INCC Folha Rosto:	1.161,58	1.149,17	1.210,47	49	4,2%
Custo Terreno Inf:	15.703.163	14.000.000	14.000.000	(1.703.163)	-10,8%
Custo Relacionados a Terreno (Unit):	3.992	2.488	2.190	(1.802)	-45,1%
Fração do Terreno[1]:	12,2% / 51,5%	8,4% / 50,2%	8,0% / 49,5%	-4,2 p.p.	-34,4%
Custo de Incorp. por uh:	1.616	5.933	4.236	2.620	162,1%
ITBI/Emol. Inf (Total)[2]:	2.402.326	3.341.002	4.083.848	1.681.522	70,0%
Custo do Ciclo (Unit):	16.627	16.808	17.088	461	2,8%
Lucro Imobiliário:	19,8%	20,0%	20,7%	1,0 p.p.	4,8%
Penalty Varandas:	N/A	N/A	N/A	N/A	
LI Ajustada:	N/A	N/A	N/A	N/A	
LI Marginal:	19,8%	N/A	21,6%	1,9 p.p.	9,5%
Exposição de caixa:	9,7%	10,6%	10,0%	0,3 p.p.	2,7%
TIR:	106,7%	94,3%	108,1%	1,4 p.p.	1,3%
Margem Bruta REF:	41,6%	41,8%	44,0%	2,4 p.p.	5,8%
Margem Bruta Econômica:	38,5%	37,8%	40,3%	1,8 p.p.	4,7%
Margem Rasa REF:	35,9%	34,0%	38,7%	2,8 p.p.	7,9%
Margem Rasa Econômica:	31,7%	28,7%	33,9%	2,3 p.p.	7,1%
Margem Contribuição Econômica:	27,4%	28,7%	28,7%	1,3 p.p.	4,7%
Payback Contingente (Régua 21 m):	20 m/ (-1 m)	20 m/ (0 m)	20 m/ (-1 m)	0	0,0%
Payback Consolidado:	20 Meses	20 Meses	20 Meses	0 Meses	0,0%

[1] Valor do terreno contratual

[2] ITBI com taxa de Aceleração

Resumo

PANORAMA SANTO ANDRÉ - SPRM - Região Metropolitana > 100mil SP

Datas e Prazos

	Compra	Lançamento	Início Obra	Término Obra	LÇTO até IO	IO até TO	Chaves	LÇTO até Chaves
Consolidado	jun-24							
SEM VAGA SEM VARANDA		out-25	jul-26	jun-28	9 meses	23 meses	out-28	36 meses
SEM VAGA COM VARANDA		out-25	jul-26	jun-28	9 meses	23 meses	out-28	36 meses
RRO DESCOBERTO E VARANDA		out-25	jul-26	jun-28	9 meses	23 meses	out-28	36 meses
CARRO COBERTO E VARANDA		out-25	jul-26	jun-28	9 meses	23 meses	out-28	36 meses
VAGA MOTO COM VARANDA		out-25	jul-26	jun-28	9 meses	23 meses	out-28	36 meses

Terreno e Incorridos

TOTAL (R$ + Perm.):	14,00 MM	**Incorrido Terreno:**	0,20 MM	**Área do Terreno (100%):**	8.654 m²
Cash:	4,50 MM	**Nº de Parcelas Cash :**	7	**Custo de terreno m²:**	1.617,7
Permuta Financeira:	9,50 MM (5,37%)			**VaR 25 (R$ mil):**	0
Permuta Física:	0,00 MM (0,00%)			**VaR 26 (R$ mil):**	0
Ato / %VGV:	0,20 MM / 0,1%			**Incorrido de Construção:**	0,43 MM

Área Líquida do Terreno:	8.654 m²
Custo de terreno m² Área Líquida:	1.617,7
Fração Terreno/Terreno + Custo Obra (%VGV):	7,9% / 49,1%
CA Máx/Proj.	4,5 / 2,4
Incorridos de Incorporação:	0,38 MM

Vendas

Fases	Nº Pavimentos	Preço Raso Unit.	Qtde	Preço Unit.	Aval. CEF	Cond. Parcela	% Pró-soluto	% TCD
SEM VAGA SEM VARANDA	T+18	230.801	336	254.947	256.658	93,8%	71,6%	57,1%
SEM VAGA COM VARANDA	T+18	252.457	90	274.843	266.011	95,3%	71,6%	42,9%
RRO DESCOBERTO E VARANDA	T+18	282.599	106	305.484	291.785	95,1%	77,1%	39,3%
CARRO COBERTO E VARANDA	T+18	287.609	108	309.751	291.785	96,3%	76,8%	37,1%
VAGA MOTO COM VARANDA	T+18	256.591	2	279.677	269.000	95,1%	71,6%	42,9%

Unidades Totais:	642	**Preço Médio:**	275.377	**Renda Média:**	4.886	**ITBI+Emol. Unit. Médio:**	5.615
Unidades Tenda:	642	**Avaliação Média:**	269.717	**Ato:**	3.829 (0,78 Salários)	**Custo do Ciclo Unit.:**	17.335
VSO:	36 Unidades	**VGV Total:**	176.791.720	**FGTS:**	4.963 (1,02 Salários)	**Preço Raso Médio:**	252.026
RET Médio:	4,0%	**VGV Tenda:**	176.791.720	**% em RET 1%:**	0%	**Adc. Tx. de Aceleração Médio:**	750

Construção

Custo Total Unit.:	113.337	**Eventuais:**	4,00%	**Área priv (m²):**	32,50	**Gape / Mês Unit.:**	11,08

Resultado

LI (R$):	**25.105.970**	**LI:**	**20,98%**	**Exposição de Caixa (R$):**	**13.705.079**	**Margem Bruta Econômica:**	**40,38%**
TIR:	**108,23%**	**LI Aprovação:**	**20,00%**	**Ger. Caixa 12 meses (R$):**	**(11.504.116)**	**Margem Bruta REF:**	**43,90%**
Exposição de Caixa:	**7,84%**	**Δ LI:**	**0,98%**	**Ger. Caixa 24 meses (R$):**	**9.555.584**	**Margem Rasa Econômica:**	**34,00%**
Payback Contingente (21 m):	**21 m/ (0 m)**	**LI Marginal:**	**21,92%**	**Ger. Caixa Marginal (R$):**	**47.039.405**	**Margem Rasa REF:**	**38,71%**
Payback Consolidado:	**21 meses**					**Margem de Contribuição Econômica:**	**28,77%**

DRE

R$ Mil - Valores Nominais - Compra	PANORAMA SANTO ANDRÉ		SEM VAGA SEM VARANDA		SEM VAGA COM VARANDA		CARRO DESCOBERTO E VARANDA		CARRO COBERTO E VARANDA		VAGA MOTO COM VARANDA	
	Nominal	%	Nominal	%	Nominal	%	Nominal	%	Nominal	%	Nominal	%
Receita	174.711	100,0%	85.036	100,0%	24.404	100,0%	31.847	100,0%	32.858	100,0%	567	100,0%
PIS/COFINS	(3.832)	2,2%	(1.865)	2,2%	(535)	2,2%	(699)	2,2%	(721)	2,2%	(12)	2,2%
Custo Total	(101.886)	59,6%	(52.876)	63,6%	(14.255)	59,7%	(17.063)	54,8%	(17.350)	54,0%	(342)	61,6%
Custo Terreno	(14.000)	8,2%	(6.928)	8,3%	(1.963)	8,2%	(2.494)	8,0%	(2.570)	8,0%	(45)	8,1%
Custo Relacionados a Terreno	(1.466)	0,9%	(741)	0,9%	(205)	0,9%	(254)	0,8%	(261)	0,8%	(5)	0,8%
Custos de Incorporação	(2.743)	1,6%	(1.413)	1,7%	(356)	1,5%	(499)	1,6%	(443)	1,4%	(31)	5,7%
Custo de Construção	(83.677)	49,0%	(43.794)	52,7%	(11.730)	49,1%	(13.816)	44,4%	(14.077)	43,8%	(261)	47,0%
Lucro Bruto Econômico	68.993	40,4%	30.295	36,4%	9.614	40,3%	14.085	45,2%	14.787	46,0%	213	38,4%
Custo para Rateio	-	0,0%	-	0,0%	-	0,0%	-	0,0%	-	0,0%	-	0,0%
Lucro Bruto Contábil	68.993	40,4%	30.295	36,4%	9.614	40,3%	14.085	45,2%	14.787	46,0%	213	38,4%
Despesas de Selling	(15.812)	9,3%	(7.719)	9,3%	(2.212)	9,3%	(2.870)	9,2%	(2.960)	9,2%	(49)	8,9%
Contingência	(4.018)	2,4%	(1.956)	2,4%	(561)	2,4%	(732)	2,4%	(756)	2,4%	(13)	2,4%
Margem de Contribuição	49.163	28,8%	20.619	24,8%	6.840	28,7%	10.483	33,7%	11.070	34,4%	151	27,1%
IR e CSLL	(3.136)	1,8%	(1.526)	1,8%	(438)	1,8%	(572)	1,8%	(590)	1,8%	(10)	1,8%
Margem Líquida	46.027	26,9%	19.093	23,0%	6.402	26,8%	9.911	31,8%	10.481	32,6%	140	25,3%
Lucro Bruto REF Unit.	123.288	43,9%	103.869	39,9%	122.830	43,8%	151.877	48,8%	156.051	49,4%	121.943	43,5%
Lucro Raso REF Unit.	99.493	38,7%	79.245	33,7%	100.014	38,8%	128.581	44,6%	133.506	45,5%	99.519	38,6%

R$ Mil - VPL - Compra	PANORAMA SANTO ANDRÉ		SEM VAGA SEM VARANDA		SEM VAGA COM VARANDA		CARRO DESCOBERTO E VARANDA		CARRO COBERTO E VARANDA		VAGA MOTO COM VARANDA	
	VP	%	VP	%	VP	%	VP	%	VP	%	VP	%
Receitas	119.693	100,0%	57.865	100,0%	16.755	100,0%	21.968	100,0%	22.705	100,0%	400	100,0%
PIS/COFINS	(2.586)	2,2%	(1.250)	2,2%	(362)	2,2%	(475)	2,2%	(491)	2,2%	(9)	2,2%
Custos e Despesas Totais	(92.002)	76,9%	(47.200)	81,6%	(12.867)	76,8%	(15.661)	71,3%	(15.957)	70,3%	(317)	79,3%
Custo Terreno	(10.802)	9,0%	(5.380)	9,3%	(1.515)	9,0%	(1.908)	8,7%	(1.964)	8,7%	(35)	8,8%
Custo Relacionados a Terreno	(1.480)	1,2%	(749)	1,3%	(207)	1,2%	(256)	1,2%	(263)	1,2%	(5)	1,2%
Custos de Incorporação	(2.253)	1,9%	(1.157)	2,0%	(290)	1,7%	(412)	1,9%	(364)	1,6%	(30)	7,5%
Custo de Construção	(60.433)	50,5%	(31.628)	54,7%	(8.472)	50,6%	(9.978)	45,4%	(10.166)	44,8%	(188)	47,1%
Despesas de Selling	(13.516)	11,3%	(6.581)	11,4%	(1.890)	11,3%	(2.463)	11,2%	(2.535)	11,2%	(47)	11,8%
Contingência	(1.402)	1,2%	(682)	1,2%	(196)	1,2%	(256)	1,2%	(264)	1,2%	(5)	1,1%
IR e CSLL	(2.116)	1,8%	(1.023)	1,8%	(296)	1,8%	(388)	1,8%	(401)	1,8%	(7)	1,8%
Lucro Imobiliário	25.106	21,0%	9.415	16,3%	3.527	21,0%	5.832	26,5%	6.258	27,6%	74	18,5%

Análise da Mancha e Implantação

Prospecção

Operações

Inteligência de Mercado

Financeiro

Pareceres

Anexos

- **DESCRIÇÃO DO IMÓVEL:** Rua Adriático, nº 541, Jardim do Estádio, CEP 09172-180, objeto da matrícula nº 131.454 do 1º Oficial de Registro de Imóveis de Santo André/SP, cadastrado perante a Prefeitura Municipal de Santo André sob a classificação fiscal nº 11.395.007.

- **PROPRIETÁRIA**: OLIVEIRAS LOCACOES LTDA.

- **CONSIDERAÇÕES JURÍDICAS SOBRE O IMÓVEL**: conforme os relatórios de Estudos Jurídicos, emitido pelo RAA Advogados em 07/06/2024, e de Estudos Técnicos, emitido pela TOP Perícia em 06/06/2024, foram apontadas, em suma, as seguintes considerações: **(a) Retificação:** o Imóvel é "tecnicamente perfeito, apresentando todas as medidas perimetrais e a área encerrada do terreno", bem como "preserva as características registrárias do imóvel, sem nenhuma diferença significativa na área ou perímetro descrito"; **(b) Loteamento**: "não há que se falar na possibilidade de existir restrição construtiva convencional que possa impedir o empreendimento almejado, posto que, constam edificações chamadas multifamiliares em ambos os confrontantes, os imóveis (objeto do estudo e confrontantes) possuem origens comuns (ou seja, em área maior, estavam contemplados no mesmo título originário)". Não obstante, houve a recomendação de que seja realizado um estudo técnico junto à Prefeitura, a fim de confirma a inexistência de restrição construtiva convencional sobre o Imóvel; **(c) Regularidade Ambiental:** certidão negativa.

- **DD IMÓVEL**: **(a) Área Construída**: não há, contudo, a ausência de cancelamento de um projeto de construção sobre o Imóvel, protocolado pela Proprietária na Prefeitura, constitui condição resolutiva contratual, a ser superada pela Proprietária. Não obstante, nos termos da Cláusula 1.4.1, a Tenda poderá adotar as medidas necessárias para promover o cancelamento, se necessário; **(b) Débitos Imobiliários: IPTU -** emitida certidão negativa de tributos imobiliários, de acordo com o artigo 130 do Código Tributário Nacional, em virtude da arrematação do Imóvel em hasta pública; Multas – de acordo com a informação passada pelo despachante documentista, não é possível a emissão de certidão junto à Prefeitura Municipal de Santo André atestando a inexistência de multas administrativas vinculadas ao contribuinte do Imóvel; **(c) Ônus e Gravames**: R.05/M.131.454 – 26/11/2024 – alienação fiduciária constituída em favor da Tenda para garantia de devolução do sinal, em caso de rescisão do CVC; **(d) Ocupação**: desocupado (BTS distratado); **(e) TAC**: não há; **(f) COMDEPHAAPASA, CONDEPHAAT e IPHAN**: COMDEPHAAPASA, CONDEPHAAT e IPHAN negativas; **(g) Desapropriação/Melhoramentos:** negativa; **(h) Função Social da Propriedade**: consulta negativa.

➢ CONSIDERAÇÕES SOBRE A PROPRIETÁRIA:

- **Passivo Atualizado:** R$ 649.931,51 – Processo nº 500285860.2025.4.03.6130 – 2ª Vara Federal de Osasco/SP
- **Patrimônio Atualizado:** R$ 35.018.658,00 – valor expressivamente superior ao passivo apurado.

➢ CONCLUSÃO:

- Em que pese tenha constado apontamento em nome da VENDEDORA, foi apresentada comprovação patrimonial muito superior a ação localizada, motivo pelo qual concordamos com o prosseguimento da aquisição, não existindo óbices e/ou elementos jurídicos intransponíveis capazes de impedir ou colocar em risco a aquisição.