Tenda

sua próxima conquista

Book Essencial de Investimento

Regional: SP – Zona Norte

Projeto: Leonel Martiniano

Data Comitê: 17/11/2025

One Page – Leonel Martiniano

Cidade	São Paulo	**Mancha de demanda**	SP - SZN2 - São Paulo Norte 2
Regional	SP	**Cluster MPR**	1 - Vermelho
Cenário de Aprovação	Aprovação	**Tipo de Aprovação**	Consolidado
Fase Anterior	N/A		
Tipo de Comitê	Essencial	**Versão da VF**	Versão 1.0: Nov

Unidades (Fases)	1794 (2)	**CA Máx | Proj**	5,8 | 5,8
Unidades com Vaga (%)	0 (0%)	**Escritura | Lançamento**	mar/28 | mai/28
Unidades com Varandas (%)	0 (0%)	**Tipologia**	F2E Plus - Concreto

Valor Líquido do Terreno (% VGV)	31.484 (7,9%)	**Un. Perm. Fís (% Ter)**	0 (0,0%)
Cash (Correção)	0 (N/A)	**%VGV Perm Fin Líquida (% Ter)**	7,9% (100,0%)
Valor R$/m²	3.192	**VAR (%VGV)**	000 (0,0%)

Custo Construção (%VGV)	183.183 (46,1%)	**Indireto Unit.**	16.997
Prazo da Obra (meses)	25	**Torre Unit.**	63.728
Custo Total Unit. | Corrigido (LPU):	102.109 | 102.280 (94)	**Infra Unit.**	10.288
Início de Obra	nov-28	**Fundação Unit.**	9.651

Preço Nominal Unit.	221.585	**VSO**	50
Preço Raso Unit.	199.510	**Referência**	Vision
Avaliação Unit.	225.000	**Renda (% em RET 1%)**	2.591 (75,0%)

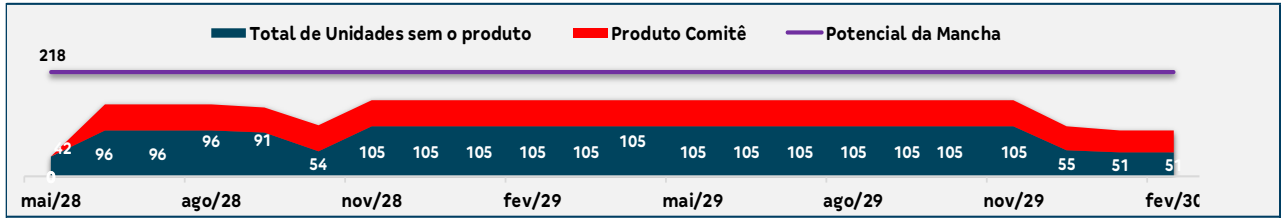

LI (Régua):	**20,6% (20,0%)**	**Margem Bruta Econômica:**	37,1%
LI Resiliência:	13,8% (N/A)	**Margem Rasa Econômica:**	29,1%
Margem Bruta REF:	39,9%	**Margem Contribuição Econômica:**	26,5%
Margem Rasa REF:	**33,3%**	**Exposição (% VGV):**	20.086 (4,4%)
TIR:	143,8%	**VGV Total:**	**397.524**
Payback Contingente (21 m) :	**20 m/ (-1 m)**	**Ger. Caixa 12 meses (R$):**	-
Payback Consolidado:	20	**Ger. Caixa 24 meses (R$):**	-

Destaques

[1] O Terreno está localizado na Rua Leonel Martiniano – Chácara Maria Trindade (região da Anhanguera), mancha ZN2 - Zona Norte de São Paulo, lindeiro ao empreendimento já entregue Solares; Terreno com gabarito T+25 e com área de 11.208 m², com zoneamento ZEIS 1, sem limite de gabarito e CA máx de 5,75x.

[2] O projeto é composto por 2 condomínios e um total de 1.794uh e VGV 394MM, sendo que: (i) Condomínio 1 com 972 uh em fase única; (iI) Condomínio 2 com 822 uh em fase única; CA do projeto está em 5,27x (92%); não estamos considerando por enquanto % de varandas - será estudado posteriormente.

[3] Condição Comercial: Permuta Financeira
- 100% Permuta Financeira: 9% de permuta bruta com desconto de 12%, resultando em uma permuta líquida de 7,92%. Estimativa na viabilidade de 35,7MM na permuta Bruta e 31,4MM na permuta líquida;
- Sem preço mínimo garantido, sem condição de correção e sem prazo para quitação;
- **OBS:** Preço do terreno aproximadamente R$ 544/CA atingido e R$ 3.169/m2 (ref. base valor terreno sobre a permuta liquida e área total de matrícula)

[4] Condições Resolutivas:
a) Etapa I: Em até 3 (três) meses para resolutivas técnicas, resolutivas jurídicas e financeira;
b) Etapa II: 36 meses após a superação da Etapa I para aprovação de projeto, contratação CEF, análise técnica, financeira e comercial para o lançamento do empreendimento;
c) A critério da Tenda podemos suspender o contrato pelo prazo limite de 12 meses, suspendo a superação das resolutivas;

[5] Projeto para aprovação no formato de **Comitê Essencial**, acima da régua de 20% de LI e baixa de 70% das unidades; temos expectativa de trazermos para comitê Ampliado no 1S26.

Pareceres

Análise da Mancha e Implantação

Prospecção

Operações

Incorporação

Inteligência de Mercado

Financeiro

Anexos

Pareceres

Área	Riscos Associados	Parecer	Flag
Jurídico Aquisição	O parecer preliminar, à exceção da verificação de débitos junto à Receita Federal em nome da proprietária no valor de R$ 66.494,14, o qual recomenda-se que seja quitado, e que apresente o extrato fiscal emitido via E-CAC, para que possa ser analisado se há outros débitos que estão impedindo a emissão da CND Federal, não identificamos, até o momento, apontamentos que onerem e coloquem em risco o presente negócio.	Ok	
Legalização	Será necessário prosseguir com a consulta técnica junto à DEUSO para melhor compreensão da proporção a ser aplicada referente ao incentivo previsto na alínea "c" do artigo 60 do PDE, o que poderá resultar em um pequeno decréscimo no número de unidades, incialmente +- 60uh. Estima-se um prazo de aproximadamente 12 meses para o retorno da consulta, prazo este considerado no cronograma de Legalização.	Ok com ressalvas	
DPP	N/A	Ok	
Inteligência de Mercado	Preço Vision como factível	Ok	
Prospecção	Projeto de borda com 1.794 uh e VGV de 394MM, divididos em dois condomínios e localizado na região da Rodovia Anhanguera. Próximimidade com projetos já entregues (SOLARES) e outros landbank. O contrato encontra-se em assinatura, com a condição de 100% permuta financeira. Seguiremos com a baixa de 70% no Comitê Essencial, com previsão para o Comitê Ampliado em 180 dias. Considerando o ponto de atenção leg mencionado, caso haja negativa da prefeitura, a redução do número de unidades habitacionais não comprometerá a viabilidade do projeto, uma vez que o pagamento do terreno será realizado integralmente por permuta financeira, sem reajuste e sem valor mínimo garantido	Ok	
Estudos Econômicos	N/A	Ok	
Comercial/Ciclo	Preço e VSO são viáveis	Ok	

Pareceres

Análise da Mancha e Implantação

Prospecção

Operações

Incorporação

Inteligência de Mercado

Financeiro

Anexos

Localização – Rua Leonel Martiniano, 180 – Chácara Maria Trindade – São Paulo - SP

Hospital municipal

Supermercado Paraíso

Pesqueiro Novo Anhanguera

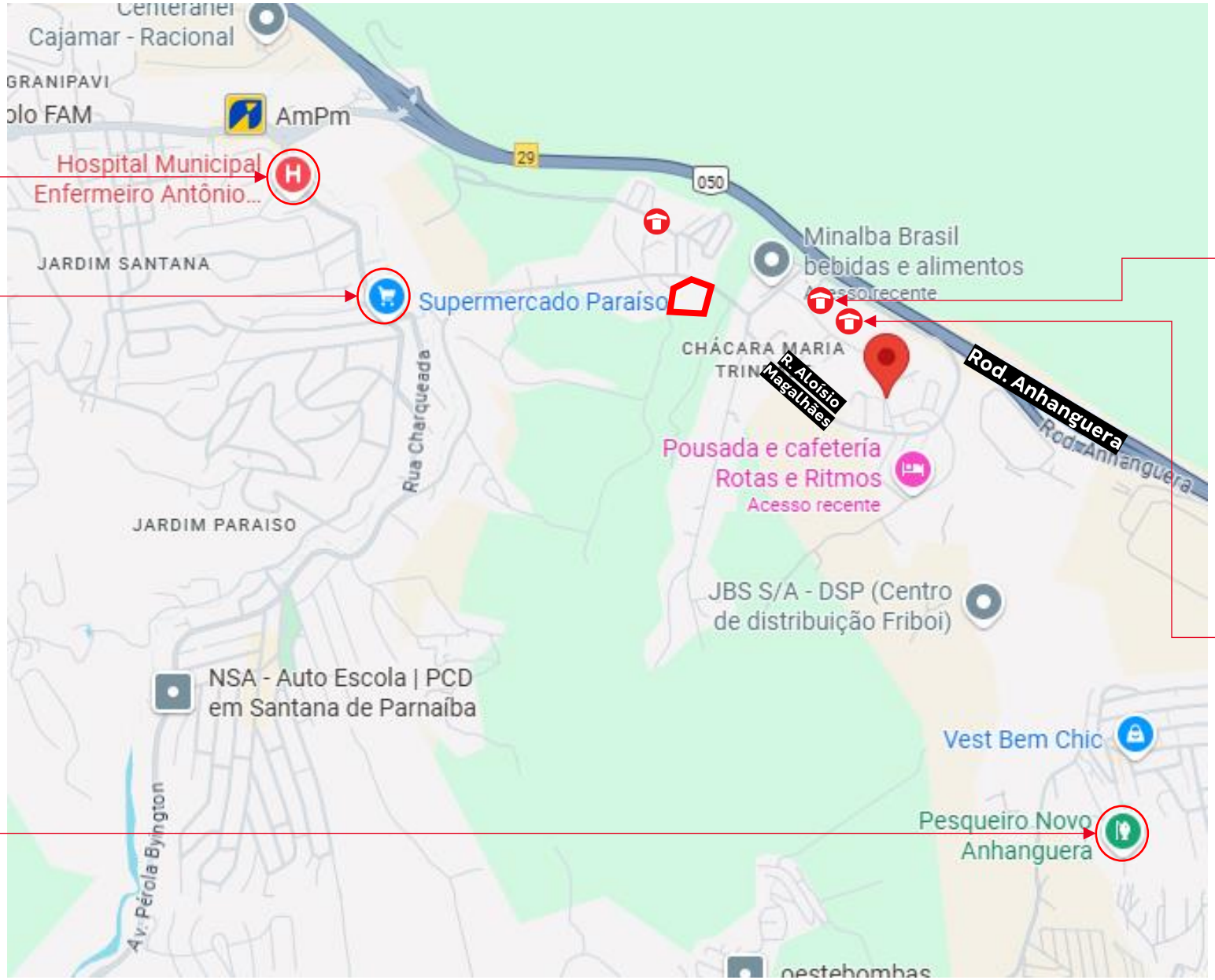

Tenda - Solares Nascente

Tenda - Solares Poente

Localização – Rua Leonel Martiniano, 180 – Chácara Maria Trindade – São Paulo - SP

IM – Mancha de Demanda

MANCHAS DE DEMANDA
• SZN – São Paulo Norte

Lançamento
1. Viva City Jaraguá
2. Viva Limão | Parque Limão
3. Melodia Jaçanã
4. Farol Cantareira

LandBank
5. Spazzio Primavera
6. Horizonte Jaraguá
7. Chácara Pirituba
8. Nilo Cairo
9. Bela Vista Jaraguá
10. Reserva Jaraguá
11. Monte Trindade
12. Leonel Martiniano

Cluster MPR – (Comitê)

Cluster 1 – Vermelho

Região

Capital

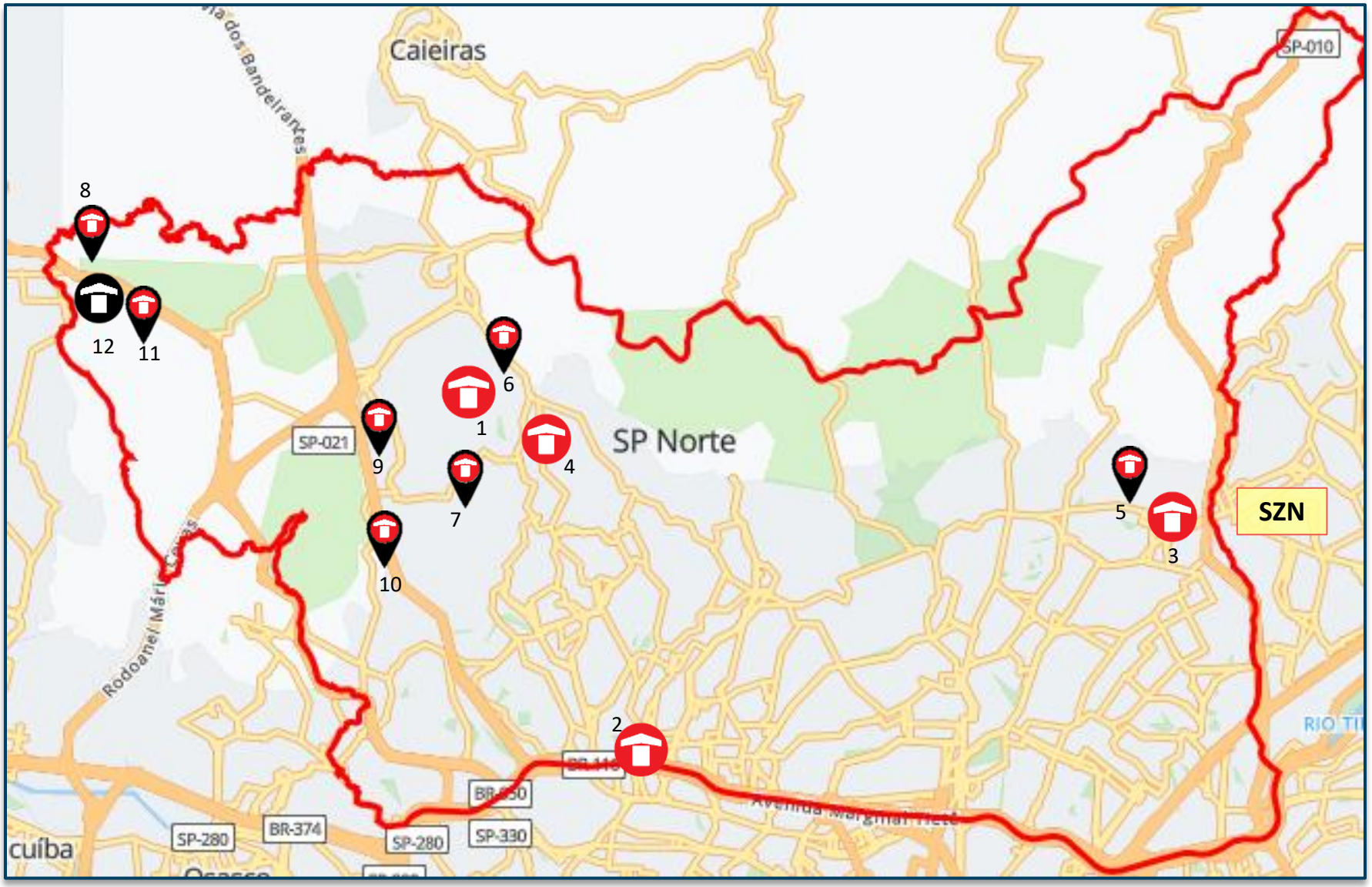

Lançados *LandBank* *Comitê*

PRODUTO

Leonel Martiniano – Comitê Essencial

Informações Gerais – Dois Condomínios			
Terreno	Área terreno (Matrícula)	11.208,00 m²	
	Área terreno (As Built)	12.557,58 m²	
	Reserva de calçada	109,73 m²	
	Menor poligonal	11.098,27 m²	
	Zoneamento	ZEIS-1	
	CA máximo	5,75	ZONA: 2,50
			INCENTIVO HIS: 1,50
			MACROÁREA: 1,25
			COTA: 0,75
	CA projetado	Cond 01: 5,49 | Cond 02: 5,05	
	Gabarito máximo	T+25	
Geral	Total UH	972 | 822	
	Total de vagas	02 (1x PCD + 1 Idoso)	
Tipologia	Tipologia	V0200	
	Gabarito	T+25	
	Lâmina	18PP + 12PP + 10PP	
	Área privativa	31,84m² | 33,59m²	
Condomínio	Unidade PCD	30 | 25	
	Unidade lazer | técnica	09 | 05	
	Torre	03 Torres em cada cond.	
	Fase	Fase única	
Lazer	Lazer coberto	Salão de Festas | Churrasqueira	
	Lazer descoberto projetado	play kids, play baby, pet place, fitness	

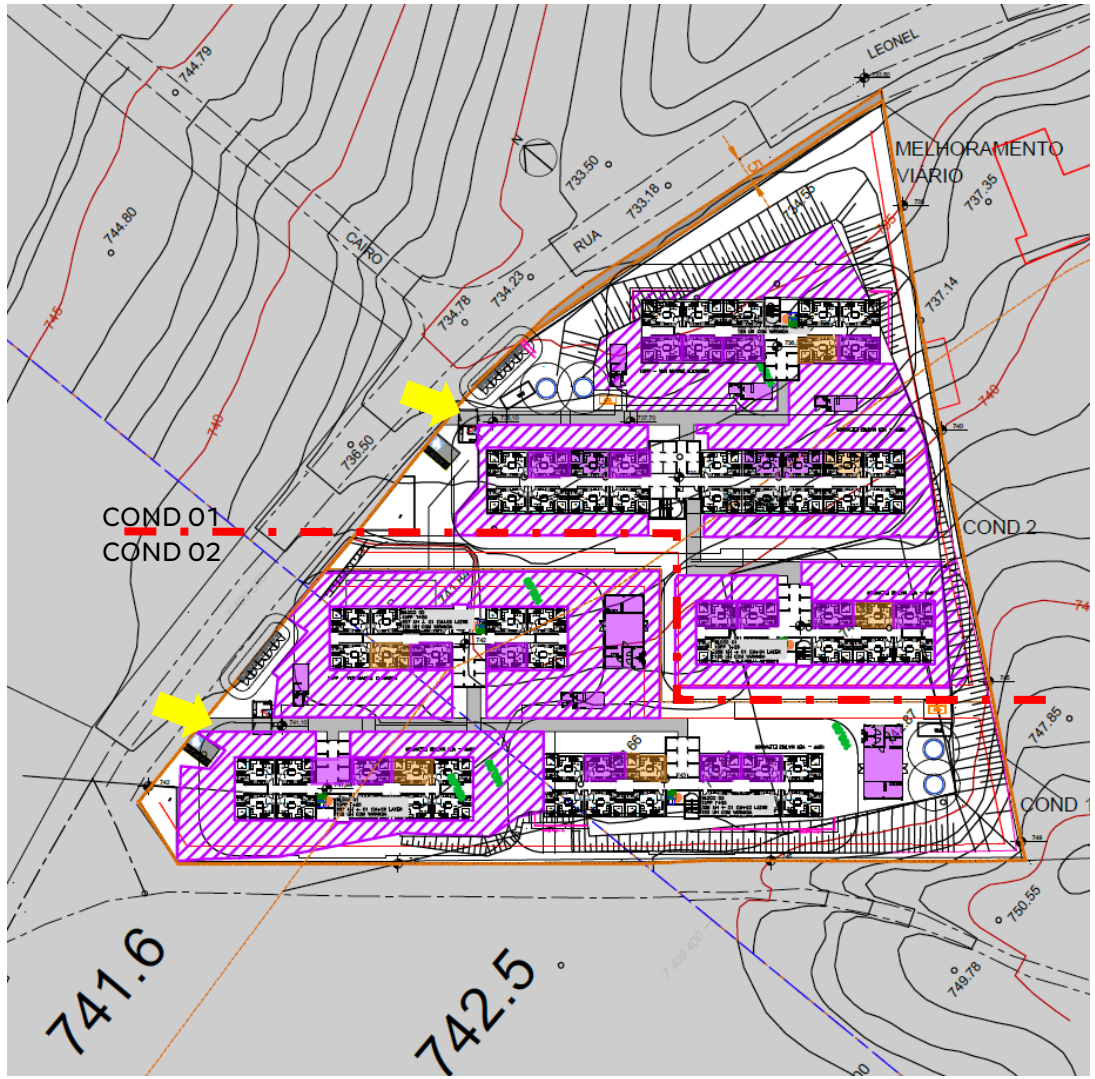

LEGENDA:

- Área técnica
- Lazer

ESTUDO DE MASSA

PRODUTO

Leonel Martiniano – Comitê Essencial

	Descrição	Criticidade	Parecer
Usabilidade	**Acesso Empreendimento**	🟢	
	Percurso do pedestre até torre	🟢	
Diferencial produto	**Prime**	Não	
	Supercondomínio	Não	
	Atributos Infra	-	A definir
	Atributos Torre	-	A definir
	Edifício Garagem	Não	

	Considerações	Criticidade	Descrição
Material analisado	KMZ	🟢	
	Mapa Digital da Cidade 2004	🟡	
	Matrícula	🟢	Matrícula tem uma área de 11.208,00m², uma diferença de 12% em relação à área indicada no as built, indicando uma possível retificação na matricula (a ser confirmada pós levantamento planialtimétrico);
	Planialtimétrico	🟡	Recebido apenas o as built do terreno;
Projeto	Área líquida	🟡	Utilizamos a poligonal definida no as built. Já para definir as cotas de dentro do terreno, foram utilizadas as cotas indicadas no google earth, visto que o terreno mostrado no MDC estava muito diferente do atual. Necessário um lev. Planialtimétrico para compatibilizar informações.
	Drenagem	🟢	

Pareceres

Análise da Mancha e Implantação

Prospecção

Operações

Incorporação

Inteligência de Mercado

Financeiro

Anexos

Condições do Negócio

- **PAGAMENTO DO TERRENO**
- Forma de pagamento: permuta financeira.
- Valor do negócio (VF): R$ 35,7MM na permuta bruta e 31,4MM na permuta liquida;
- Valor do negócio (contrato e ECV): R$ 27.000.000,00; O valor informado corresponde à estimativa inicial de repasses ao vendedor. Durante a negociação, obtivemos um acréscimo de UH, resultando em repasses superiores aos inicialmente formalizados. Ressalta-se que, nesse caso, a negociação se concentrou exclusivamente no percentual de participação do vendedor.
- Permuta Financeira: 9% do VGV bruto, com carência inicial de 6 meses para início dos repasses. Não há compromisso ou obrigação adicional além da permuta bruta de 9%, sem preço mínimo garantido, sem previsão de correção e sem prazo determinado para quitação. Considerando o desconto de 12%, decorrente de despesas com *selling*, marketing e impostos, a permuta líquida resulta em **7,92% do VGV**.
- Não incidirá qualquer forma de correção ou reajuste sobre o valor acordado, salvo aqueles que venham a resultar em acréscimo do VGV;

- **ANTECIPAÇÃO DE DESPESAS**
- Não há previsão para antecipação;

- **GARANTIAS**

Para o Vendedor:

- Será firmada escritura de novação e confissão de dívida, substituindo o pagamento à vista da nota promissória por repasses de participação conforme previsto em contrato. A nota promissória será inutilizada, e a minuta da escritura seguirá os mesmos termos acordados entre as partes.

- Data da escritura prevista: **Março / 2028**

Condições do Negócio

- **CORRETAGEM / INTERMEDIAÇÃO IMOBILIÁRIA (Cláusula 8 da PVC)**

• Neste negócio não há intermediários imobiliários envolvidos, razão pela qual a operação está isenta de quaisquer pagamentos de honorários de corretagem. Todas as tratativas foram conduzidas diretamente entre o proprietário e a Tenda;

- **PRAZOS CONTRATUAIS**
- Etapa I: Prazo 90 dias para resolutivas técnica, jurídica e financeira;
- Etapa II: Em até 36 meses após superação da Etapa I para aprovação do projeto, obtenção do financiamento CEF. viabilidade técnica e financeira, e outorga da ECV;

A critério da TENDA, podemos suspender os prazos contratuais pelo prazo máximo de 12 meses para superação de qualquer das condições resolutivas;

- **CONDIÇÕES RESOLUTIVAS / DISTRATO (Cláusula 6 da PVC)**

• O CVC prevê cláusulas resolutivas específicas, que asseguram à Tenda o direito de rescindir o contrato a seu único e exclusivo critério: como inviabilidades técnicas e financeira do empreendimento

• Procedimento de distrato: Decorrido o prazo informado acima (PRAZOS CONTRATUAIS), a TENDA deverá notificar os vendedores informando quanto a superação das condições resolutivas ou rescisão contratual sem penalidade para as partes

- **INFORMAÇÕES ADICIONAIS**

• O imóvel será entregue livre e desimpedido, e atualmente está ocupado pela empresa proprietária, a qual já deu início à desmobilização de suas atividades no local e vem desocupando o imóvel gradualmente.

• O Imóvel é urbano e possui IPTU.

• Não há condições especificas no contrato que possam acarretar prejuízo na viabilidade.

Pareceres

Análise da Mancha e Implantação

Prospecção

Operações

Incorporação

Inteligência de Mercado

Financeiro

Anexos

Custo de Construção – SIMULADOR – CONDOMÍNIO 1

ESTIMATIVA

DADOS DA OBRA		BASES		PRAZOS DE OBRA	
Regional:	SP	Data:	novembro-25	Pré Forma:	5,7 meses
Endereço:		Revisão:	R00	Estrutura:	10,2 meses
Total de UH:	**988**	LPU:	LPU 94	Pós Forma:	9,0 meses
Total Torres:	3	LVS:	agosto-25	**TOTAL:**	**25,0 meses**
Produtos:	F2E+ Modular	INCC:	1.216,706		
Tipologia:	MODULAR 10PP/16PP T+15			Jogos de Formas:	2
				Takt:	2+2

CUSTOS DE CONSTRUÇÃO

	CUSTO	R$ / UND
CUSTO TOTAL I	**R$ 98.872.917**	**R$ 101.097**
INDIRETO	R$ 16.135.297	R$ 16.498
TORRE	R$ 62.340.365	R$ 63.743
INFRA	R$ 10.064.153	R$ 10.291
FUNDAÇÃO	R$ 9.440.602	R$ 9.653
ETE	R$ 0	R$ 0
EEE	R$ 0	R$ 0
CONTENÇÃO	R$ 88.525	R$ 91
TERRAPLENAGEM	R$ 803.975	R$ 822
CUSTO TOTAL II	**R$ 479.657**	**R$ 490**
VIÁRIO	R$ 86.009	R$ 88
DRENAGEM	R$ 0	R$ 0
EXTENSÃO ELÉTRICA	R$ 103.252	R$ 106
EXTENSÃO HIDRÁULICA	R$ 290.396	R$ 297
CUSTO TOTAL I + II	**R$ 99.352.574**	**R$ 101.587**
CUSTO TOTAL III	**R$ 0**	**R$ 0**
INCORRIDOS NÃO APROVEITADOS	R$ 0	R$ 0
CUSTO TOTAL I A III	**R$ 99.352.574**	**R$ 101.587**
CUSTO TOTAL I A IV	**R$ 99.352.574**	**R$ 101.587**

OBSERVAÇÕES GERAIS

Parâmetro terraplenagem: Nível 2
Parâmetro Contenção: Nível 1

RATEIO FASEAMENTO

% de Varanda: 0%
Possui Piscina: Não
ETE: Não
EEE: Não

Custo de Construção – SIMULADOR – CONDOMÍNIO 2

ESTIMATIVA

DADOS DA OBRA		BASES		PRAZOS DE OBRA	
Regional:	SP	Data:	novembro-25	Pré Forma:	5,7 meses
Endereço:		Revisão:	R00	Estrutura:	8,6 meses
Total de UH:	**832**	LPU:	LPU 94	Pós Forma:	9,0 meses
Total Torres:	3	LVS:	agosto-25	**TOTAL:**	**24,0 meses**
Produtos:	F2E+ Modular	INCC:	1.216,706		
Tipologia:	MODULAR 10PP/16PP T+15			Jogos de Formas:	2
				Takt:	2+2

CUSTOS DE CONSTRUÇÃO

	CUSTO	R$ / UND
CUSTO TOTAL I	**R$ 84.166.063**	**R$ 102.143**
INDIRETO	R$ 14.492.278	R$ 17.588
TORRE	R$ 52.497.149	R$ 63.710
INFRA	R$ 8.475.076	R$ 10.285
FUNDAÇÃO	R$ 7.949.981	R$ 9.648
ETE	R$ 0	R$ 0
EEE	R$ 0	R$ 0
CONTENÇÃO	R$ 74.547	R$ 90
TERRAPLENAGEM	R$ 677.032	R$ 822
CUSTO TOTAL II	**R$ 479.657**	**R$ 582**
VIÁRIO	R$ 86.009	R$ 104
DRENAGEM	R$ 0	R$ 0
EXTENSÃO ELÉTRICA	R$ 103.252	R$ 125
EXTENSÃO HIDRÁULICA	R$ 290.396	R$ 352
CUSTO TOTAL I + II	**R$ 84.645.719**	**R$ 102.725**
CUSTO TOTAL III	**R$ 0**	**R$ 0**
INCORRIDOS NÃO APROVEITADOS	R$ 0	R$ 0
CUSTO TOTAL I A III	**R$ 84.645.719**	**R$ 102.725**
CUSTO TOTAL I A IV	**R$ 84.645.719**	**R$ 102.725**

OBSERVAÇÕES GERAIS

Parâmetro terraplenagem: Nível 2
Parâmetro Contenção: Nível 1

RATEIO FASEAMENTO

% de Varanda: 0%
Possui Piscina: Não
ETE: Não
EEE: Não

Pareceres

Análise da Mancha e Implantação

Prospecção

Operações

Incorporação

Inteligência de Mercado

Financeiro

Anexos

AMBIENTAL + LEGALIZAÇÃO – Paramétrico de custos

Tenda

REGIONAL SP

PARAMÉTRICO DE CUSTOS LEGALIZAÇÃO

DADOS		QUANDO APLICAR
Quantidade de unidades	1.794	
O Empreendimento terá R2V?	NÃO	
Qual a área do Terreno?	12.558	
Quanto % do terreno Possui árvore?	1%	Se possivel contas arvores, considerar 6m² X quantidade de arvores / area do terreno. Caso não seja possivel, estimar por poligonal
Possível Área Contaminada?	SIM	Terrenos com histórico de uso industrial anterior; Os vizinhos do entorno podem possuem uso geradores de contaminantes (posto de gasolina, fabricas, gasodutos, etc...);
Esta Cadastrado como Área Possivelmente Contaminada nos Orgão Publicos?	NÃO	Quando no GEOSAMPA estiver classificado como área possivelmente contaminada
Parcelamento do Solo?	S/ DOAÇÃO	
Quantos Condomínios?	2	Incluir a quantidade de condomínios que serão gerados no licenciamento

ABERTURA	$ FINAL	MÉTRICA
Compensação Ambiental	R$ 533.609	média histórica/ m² de terreno + acrescimo de 30% do valor com aplicação de R2V
Laudos, EIV, EIARIMA	R$ 15.000	15k fixo
Emolumentos e Taxas	R$ 35.000	5k - Revalidação de Certidões + 30k aprovação CETESB (contaminação) quando for classificado como potencialmente contaminado ou existir a possibilidade de ter contaminação;
Assessorias	R$ 5.000	Custas second opinion Ambiental
Cópias, Plotagens, Autenticações, etc...	R$ 15.000	15k fixo
Contra Partida	R$ 836.493	Não temos contrapartida para SP Capital Considerado custas de contaminação/ remediação histórica dos empreendimentos em LB/ m² de terreno
Projeto de criação e Legal	R$ 34.500	1.5k/condomínio de tercerização PL + 4k/condomínio de NBR + 5k complemento plani + 15k para parcelamento do solo (quando houver) + 3.5k para pl grapro (quando houver)
Total	**R$ 1.474.602**	**R$ 822/uh**

CRITÉRIOS DE INPUT DO SIMULADOR

- Projeto com desmembramento
- Projeto sem doação de área verde ou institucional;
- Empreendimento 100% EHIS
- Previsto uma verba de R$372k para demolição;
- Não foi prevista verba para remediação; contudo, o CVC estabelece que, em caso de confirmação de contaminação, poderemos antecipar o valor necessário e descontar 100% dos custos de remediação

JURÍDICO – Paramétrico de custos

Tenda

REGIONAL SP

PARAMÉTRICO DE CUSTOS JURÍDICO IMOBILIÁRIO

DADOS		QUANDO APLICAR
Quantidade Unidades	1.794	
Área Construída	71.312 m²	
Tem SQL?	SIM	
Valor do carne de IPTU	R$ 13.448	Considerar sempre o valor do caner de IPTU do ano de aplicação
Área de Matrícula	11.208	
Retificação?	SIM	Quando a matrícula não tiver o encerramento descrito e/ou detalhamento dos perímetro; Quando houver necessária de de acrescimo ou exclusão de áreas do real para implantação do empreendimento;
Quantos Condomínios?	2	
Quantos Proprietários de terreno?	1	
Parcelamento do Solo?	S/ DOAÇÃO	C/ Doação: Quando matrícula tiver mais de 20.000m² ou for necessário abertura de mais lotes
Remembramento de Matrículas?	SIM	Quando a composição do empreendimento é composta por 2 ou mais matrículas para incorporar;
Com qual valor o terreno será escriturado?	R$ 27.000.000	

ABERTURA	$ FINAL	MÉTRICA
Desdobro de IPTU	R$ 5.000	R$ 2.5k/ condomínio
Instituição de Condomínio	R$ 2.242.500	R$ 1250/uh
Averbação da Construção	R$ 539.115	Área Construída(m²) X 4 meses de Cobrança X Índice Histórico (atual 1,79/m²)
Procuração Societária	R$ 5.000	5k fixo
IPTU (Anual)	R$ 13.448	Valor do caner vigente de IPTU ou em caso de não tenha IPTU, considerado para calculo área da matrícula X Índice Histórico (atual 1,79/m²)
Registro de Incorporação	R$ 476.740	R$ 210/uh + 40k quando houver necessidade de retificação
Honorário Incorporação	R$ -	Não gastamos mais com honorários de incorporação Considerado IPTU Retroativo por não ter SQL: $ IPTU X 5 anos
Cópias e Autenticações	R$ 15.000	15k fixo
Honorário Aquisição	R$ 80.000	120k - 2 ou mais prorietários do terreno 80k - 1 proprietário do terreno
Registro de Escritura	R$ 202.500	Valor do terreno X 0,75%
ITBI Terreno	R$ 810.000	Valor do terreno X 3%
Total	**R$ 4.389.303**	**R$ 2.447/uh**

CRONOGRAMA PRÉVIO

APROVAÇÃO DE CONDOMÍNIO
TERRENO <20.000
APROVAÇÃO EM GRAPROHAB >800UH
COM CONTAMINADA
IPHAN - Ñ SE APLICA
COM RETIFICAÇÃO

PRAZO
30 meses

CIE CIA L

MÊS	RESP	ETAPA	INÍCIO	FIM	STATUS/ PRAZO (dias)
0	PROSP	**COMITÊ INVESTIMENTO ESSENCIAL**	17/11/25	17/11/25	-
	NEG	REUNIÃO PASSAGEM/ PARTIDA	24/11/25	24/11/25	-
	JRI	MATERIAL RETIFICAÇÃO	1/12/25	30/1/26	60
	JRI	UNIFICAÇÃO DE MATRICULA	31/1/26	28/9/26	240
	LEG	CONSULTA DEUSO	24/11/25	24/11/26	365
	NEG	DIRETRIZ SABESP	1/12/25	15/1/26	45
	PRÉ-LEG	INVESTIGAÇÃO AMBIENTAL	4/12/25	3/4/26	120
	DPP	ELABORAÇÃO AP	4/2/26	24/2/26	20
	CUSTOS	PARAMETRIZAÇÃO	11/3/26	31/3/26	20
	NEG	CONFIRMAÇÃO FINANCEIRA	8/4/26	18/4/26	10
6	**NEG**	**COMITÊ INVESTIMENTO AMPLIADO**	**23/5/26**	**23/5/26**	-
	GETEC	ENGENHARIA SIMULTÂNEA	15/4/26	30/5/26	45
	GETEC	ELABORAÇÃO PROJETO SABESP	25/4/26	23/8/26	120
	GETEC	APROVAÇÃO SABESP	30/8/26	28/12/26	120
	GETEC	EP KIT LEGAL	31/5/26	2/10/26	124
	PL	PL DE DESMEMBRAMENTO	30/6/26	30/7/26	30
	PL	ALVARÁ DE DESMEMBRAMENTO	9/8/26	5/2/27	180
	JUR	ABERTURA DE MATRÍCULA CARTÓRIO	15/2/27	17/3/27	30
	PL	ELABORAÇÃO PL CONDOMÍNIO	7/12/26	6/1/27	30
	LEG	CETESB	18/4/26	15/10/26	180
	LEG	ALVARÁ DE APROVAÇÃO (AR)	24/3/27	19/12/27	270
	LEG	APROVAÇÃO GRAPROHAB	20/9/27	18/3/28	180
	NEG	**COMITÊ DE ESCRITURA/ LANÇAMENTO**	**25/3/28**	**25/3/28**	-
	JRI	ESCRITURA	27/2/28	28/3/28	30
	JRI	REGISTRO INCORPORAÇÃO	29/3/28	28/4/28	30
	CRD	LAUDOS CEF	10/2/28	10/5/28	90
30	**NEG**	**LANÇAMENTO**	**10/5/28**	**10/5/28**	-

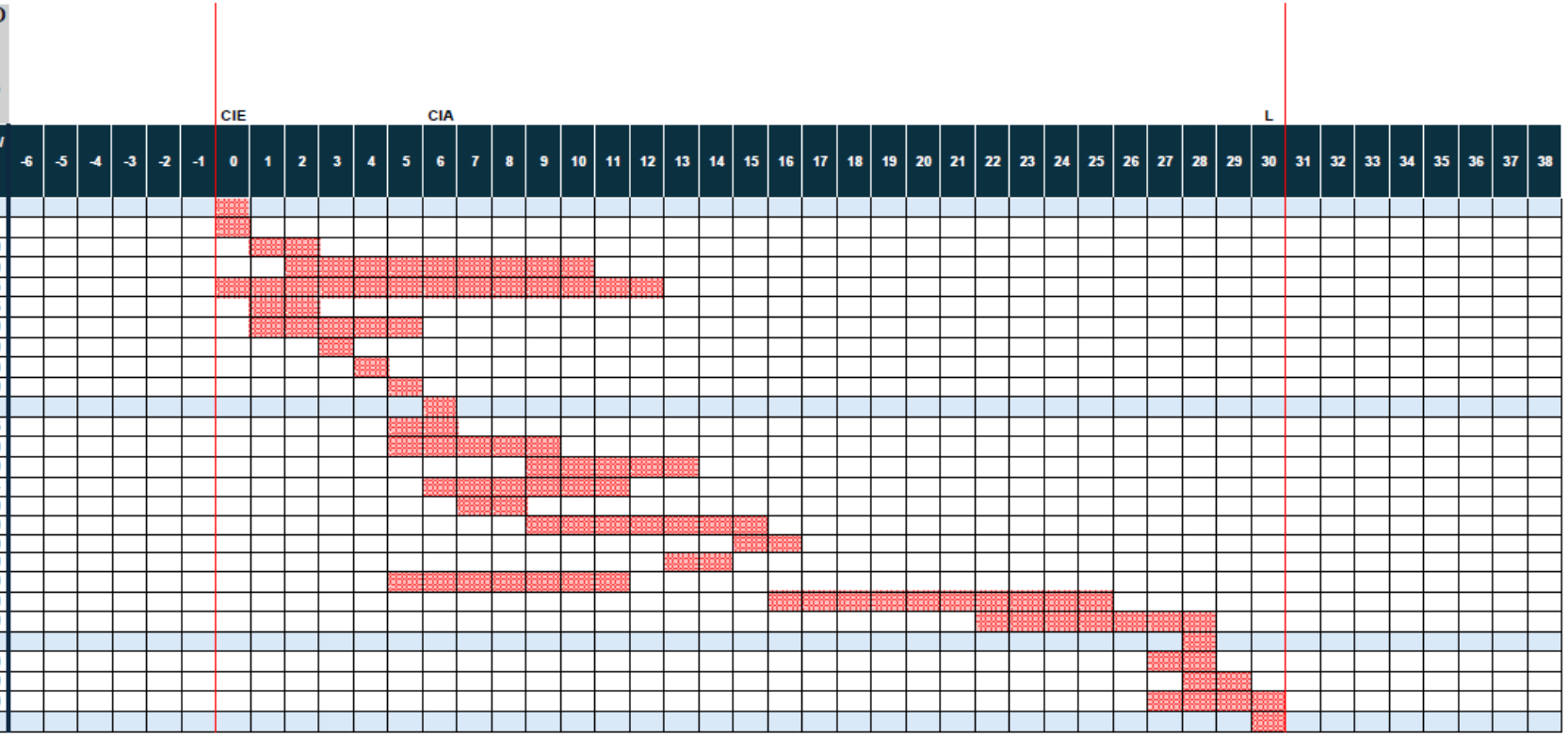

PRAZO PARA SUPERAÇÃO 1ª ETAPA DE RESOLUTIVAS E PARA APROVAÇÃO DO COMITÊ AMPLIADO: **Jun/26**

Pareceres

Análise da Mancha e Implantação

Prospecção

Operações

Incorporação

Inteligência de Mercado

Financeiro

Anexos

Demanda e Distribuição da Mancha

Potencial de Demanda			Lançados		Lanç + Landbank	
Mancha	CÓD.	Shr.	ANO	MÊS	ANO	MÊS
São Paulo Norte	SZN	30%	2.185	182	2.621	218

Faixas MCMV	Empreendimento	Renda	Lançamento	mai/28	jun/28	jul/28	ago/28	set/28	out/28	nov/28	dez/28	jan/29	fev/29	mar/29	abr/29	mai/29	jun/29	jul/29	ago/29	set/29	out/29	nov/29	dez/29	jan/30	fev/30
Faixa 1	Monte Trindade	2.796	mar-27	42	42	42	42	37																	
Faixa 1	**Leonel Martiniano - Fase 1**	**2.591**	**mai-28**		**54**	**54**	**54**	**54**	**54**	**54**	**54**	**54**	**54**	**54**	**54**	**54**	**54**	**54**	**54**	**54**	**54**	**54**	**4**		
Faixa 1	**Leonel Martiniano - Fase 2**	**2.591**	**nov-29**																				**46**	**46**	**46**
Faixa 2	Spazio Primavera I Fase 1	3.380	out-28							51	51	51	51	51	51	51	51	51	51	51	51	51	51	51	51
Total de Vendas Lançados				**0**	**0**	**0**	**0**	**0**	**0**	**0**	**0**	**0**	**0**	**0**	**0**	**0**	**0**	**0**	**0**	**0**	**0**	**0**	**0**	**0**	**0**
Total de Vendas Lançados + Landbank				**42**	**96**	**96**	**96**	**91**	**54**	**105**	**105**	**105**	**105**	**105**	**105**	**105**	**105**	**105**	**105**	**105**	**105**	**105**	**101**	**97**	**97**
Total Mancha | Faixa 1				*100%*	*100%*	*100%*	*100%*	*100%*	*100%*	*51%*	*51%*	*51%*	*51%*	*51%*	*51%*	*51%*	*51%*	*51%*	*51%*	*51%*	*51%*	*51%*	*50%*	*47%*	*47%*
Total Mancha | Faixa 2				*0%*	*0%*	*0%*	*0%*	*0%*	*0%*	*49%*	*49%*	*49%*	*49%*	*49%*	*49%*	*49%*	*49%*	*49%*	*49%*	*49%*	*49%*	*49%*	*50%*	*53%*	*53%*
Total Mancha | Faixa 3				*0%*	*0%*	*0%*	*0%*	*0%*	*0%*	*0%*	*0%*	*0%*	*0%*	*0%*	*0%*	*0%*	*0%*	*0%*	*0%*	*0%*	*0%*	*0%*	*0%*	*0%*	*0%*

Parecer de I.M sobre a mancha:

O projeto analisado em comitê está em linha com o potencial teórico de demanda calculado para a mancha. (Total Lanç + Landbank)

Canibalização:

Sem Risco de Canibalização

Leonel Martiniano | Mapa Concorrência

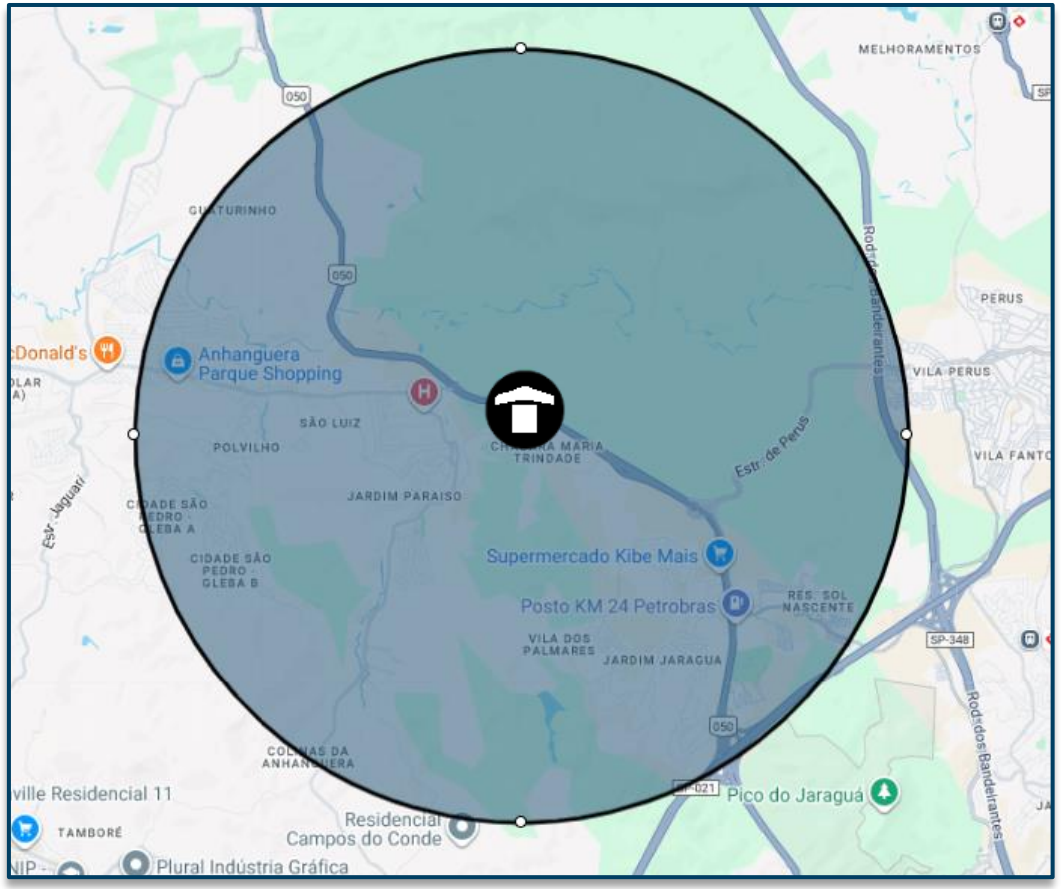

Diagnóstico Concorrência

- A região não possuí empreendimentos lançados nos últimos 3 anos.
- Em 2020 a Tenda lançou o empreendimento Solaris na região e capturou cerca de 2,2k de renda média na época.

Leonel Martiniano
TENDA

	Distância Tenda (km)	
Região 1 Km	População	2.130
	Dens. Demográfica	682
	Renda (R$)	4.086
	Classe Social	C1 (de R$ 3.1K a 5.4K)
	PEA Dia	2.026

Simulação de Preço

Informações Viabilidade

Projeto:	Leonel Martiniano
Tipo:	**Uh Tipo**
Método	**Vision**
Avaliação	225.000
Renda Inicial (VF)	2.591
Renda Final*	-
% RET1	75%

Tipo:	VF	R$
Ato	0,45	1.149
FGTS	0,57	1.447
Financiamento	96,83%	148.830
Subsídio	97,28%	17.687
Prazo de Pró-soluto	30	30
Pró-Soluto	103,89%	29.341
Preço Raso (RS)	198.454	198.454
TCD	83,88%	21.908
VSO	54	54
Preço de Venda	**224.859**	**224.859**
Elasticidade	-2,000%	-2,000%
Preço de Venda Final	**220.362**	**220.362**
Preço Raso (R$)	**198.454**	
% de Raso	**90,06%**	
BP25 - Não Inflacionado	**-**	
BP25 - Inflacionado	**-**	

Análise de Preço

Informações Viabilidade

Projeto:	Leonel Martiniano
Tipo:	**Faixa 2**
Método	**Vision**
Avaliação	225.000
Renda Inicial (VF)	2.591
Renda Final*	-

Tipo:	VF	R$
Ato	0,45	1.149
FGTS	0,57	1.447
Financiamento	96,83%	148.830
Subsídio	97,28%	17.687
Prazo de Pró-soluto	30	30
Pró-Soluto	103,89%	29.341
Preço Raso (RS)	198.454	198.454
TCD	83,88%	21.908
VSO	54	54
Preço de Venda	**224.769**	**224.769**
Elasticidade	-2,000%	-2,000%
Preço de Venda Final	**220.362**	**220.362**
Preço Raso (R$)	**198.454**	
% de Raso	**90,06%**	
Raso Todas as Fases	**199.508**	
Nominal Todas as Fases	**221.583**	

1

Análise de Riscos | Farol IM

IM avalia o Preço Vision como **factível**.

1) I.M está de acordo com o preço Vision estimado para o Leonel Martiniano. O projeto está inserido em uma região de borda, e a renda estimada no parecer está coerente com o perfil socioeconômico local. Em 2020, lançamos o empreendimento Solaris na mesma macrorregião, que à época capturou uma renda média de R$ 2,2 mil.

Conforme consta no slide "Panorama de Concorrência, não mapeamos nenhum concorrente na região.

	Preço Real					Preço Norm. (30m)	
	Avaliação	Preço Raso	Renda Mediana	VSO	PSOL	Δ PSOL	Preço Raso
Leonel Martiniano	225.000	198.454	2.591	54	30	0	198.454
Viva City Jaraguá	222.051	187.494	3.017	30	8	22.411	209.906
Farol Cantareira	224.661	190.578	2.927	18	13	17.453	208.030
Melodia Jaçanã	260.560	228.615	4.052	31	23	8.137	236.752

Resumo de Preços

Vision

Nome Fase	Tipologia	Renda	Ato	FGTS	Cond.	Subsídio	PSOL	TCD	VSO	Nom. Pré	Avali.	Elast.	Nom. Pós	Raso Pós	PSOL (m)	RET1
Leonel Martiniano - Fase 2	Uh Tipo	2.591	0,45	0,57	96,8%	97,3%	105,6%	85,3%	46	223.861	225.000	-0,3704%	223.032	200.760	29	75%

Clico Financeiro – Análise de Mancha

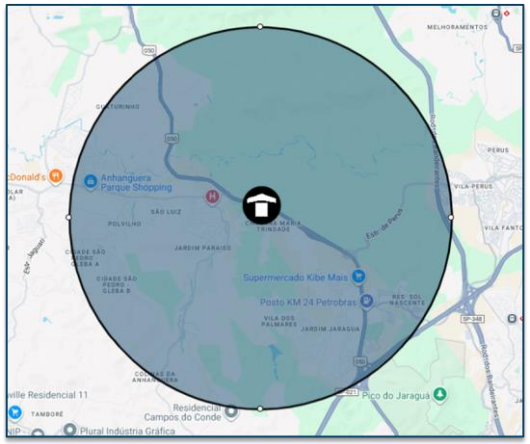

Parecer Ciclo

O Ciclo validou tanto o preço quanto o VSO como viáveis. A Região é de borda e não há concorrentes. O VSO é alto porém com preços rasos e nominais competitivos, para uma excelente execução.

Pareceres

Análise da Mancha e Implantação

Prospecção

Operações

Incorporação

Inteligência de Mercado

Financeiro

Anexos

Informações Financeiras

Leonel - SP - São Paulo Capital

Datas e Prazos

	Compra	Lançamento	Início Obra	Término Obra	LÇTO até IO	IO até TO	Chaves	LÇTO até Chaves
Consolidado	nov-25							
Leonel F1		mai-28	nov-28	dez-30	6 meses	25 meses	mai-31	36 meses
Leonel F2		nov-29	mai-30	mai-32	6 meses	24 meses	nov-32	36 meses

Terreno e Incorridos

TOTAL (R$ + Perm.):	35,78 MM	**Incorrido Terreno:**	0,00 MM	**Área do Terreno (100%):**	11.208 m²
Cash:	0,00 MM	**Nº de Parcelas Cash :**	0	**Custo de terreno m²:**	3.192,1
Permuta Financeira:	35,78 MM (9,00%)			**VaR 25 (R$ mil):**	0
Permuta Física:	0,00 MM (0,00%)			**VaR 26 (R$ mil):**	0
Ato / %VGV:	0,00 MM / 0,0%			**Incorrido de Construção:**	0,00 MM

Área Líquida do Terreno:	11.208 m²
Custo de terreno m² Área Líquida:	3.192,1
Fração Terreno/Terreno + Custo Obra (%VGV):	9,0% / 55,1%
CA Máx/Proj.	5,8 / 5,8
Incorridos de Incorporação:	0,00 MM

Vendas

Fases	Nº Pavimentos	Preço Raso Unit.	Qtde	Preço Unit.	Aval. CEF	Cond. Parcela	% Pró-soluto	% TCD
Leonel F1	T+25	198.455	972	220.362	225.000	96,8%	103,9%	83,9%
Leonel F2	T+25	200.760	822	223.032	225.000	96,8%	105,6%	85,3%

Unidades Totais:	1.794	**Preço Médio:**	221.585	**Renda Média:**	2.591	**ITBI+Emol. Unit. Médio:**	2.500
Unidades Tenda:	1.794	**Avaliação Média:**	225.000	**Ato:**	1.172 (0,45 Salários)	**Custo do Ciclo Unit.:**	13.949
VSO:	50 Unidades	**VGV Total:**	397.523.923	**FGTS:**	1.477 (0,57 Salários)	**Preço Raso Médio:**	199.510
RET Médio:	1,8%	**VGV Tenda:**	397.523.923	**% em RET 1%:**	75%	**Adc. Tx. de Aceleração Médio:**	750

Construção

Custo Total Unit. | Corrigido:	102.109 | 102.280	**Eventuais:**	4,00%	**Área priv (m²):**	32,00	**Gape / Mês Unit.:**	11,08

Resultado

LI (R$):	**38.550.715**	**LI:**	**20,58%**	**Exposição de Caixa (R$):**	**20.086.084**	**Margem Bruta Econômica:**	**37,06%**
TIR:	**143,75%**	**LI Aprovação:**	**20,00%**	**Ger. Caixa 12 meses (R$):**	**0**	**Margem Bruta REF:**	**39,89%**
Exposição de Caixa:	**4,35%**	**Δ LI:**	**0,58%**	**Ger. Caixa 24 meses (R$):**	**0**	**Margem Rasa Econômica:**	**29,09%**
Payback Contingente (21 m):	**20 m/ (-1 m)**	**LI Resiliência:**	**13,81%**	**Ger. Caixa Marginal (R$):**	**117.489.423**	**Margem Rasa REF:**	**33,25%**
Payback Consolidado:	**20 meses**					**Margem de Contribuição Econômica:**	**26,51%**

Informações Financeiras

R$ Mil - Valores Nominais - Compra	Leonel		Leonel F1		Leonel F2	
	Nominal	%	Nominal	%	Nominal	%
Receita	461.346	100,0%	240.229	100,0%	221.118	100,0%
PIS/COFINS	(4.427)	1,0%	(2.305)	1,0%	(2.122)	1,0%
Custo Total	(287.569)	62,9%	(149.991)	63,0%	(137.578)	62,8%
Custo Terreno	(36.539)	8,0%	(19.026)	8,0%	(17.513)	8,0%
Custo Relacionados a Terreno	(1.051)	0,2%	(550)	0,2%	(500)	0,2%
Custos de Incorporação	(7.607)	1,7%	(3.989)	1,7%	(3.618)	1,7%
Custo de Construção	(242.372)	53,0%	(126.425)	53,1%	(115.947)	52,9%
Lucro Bruto Econômico	169.350	37,1%	87.933	37,0%	81.418	37,2%
Custo para Rateio	-	0,0%	-	0,0%	-	0,0%
Lucro Bruto Contábil	169.350	37,1%	87.933	37,0%	81.418	37,2%
Despesas de Selling	(37.628)	8,2%	(19.562)	8,2%	(18.066)	8,2%
Contingência	(10.611)	2,3%	(5.525)	2,3%	(5.086)	2,3%
Margem de Contribuição	121.112	26,5%	62.845	26,4%	58.267	26,6%
IR e CSLL	(3.622)	0,8%	(1.886)	0,8%	(1.736)	0,8%
Margem Líquida	117.489	25,7%	60.959	25,6%	56.530	25,8%
Lucro Bruto REF Unit.	105.458	39,9%	101.103	39,8%	110.609	40,0%
Lucro Raso REF Unit.	79.152	33,3%	75.879	33,2%	83.023	33,3%

R$ Mil - VPL - Compra	Leonel		Leonel F1		Leonel F2	
	VP	%	VP	%	VP	%
Receitas	187.337	100,0%	109.344	100,0%	77.993	100,0%
PIS/COFINS	(1.771)	0,9%	(1.034)	0,9%	(737)	0,9%
Custos e Despesas Totais	(147.015)	78,5%	(85.742)	78,4%	(61.273)	78,6%
Custo Terreno	(14.203)	7,6%	(8.290)	7,6%	(5.913)	7,6%
Custo Relacionados a Terreno	(669)	0,4%	(350)	0,3%	(319)	0,4%
Custos de Incorporação	(3.495)	1,9%	(1.987)	1,8%	(1.508)	1,9%
Custo de Construção	(106.141)	56,7%	(61.969)	56,7%	(44.172)	56,6%
Despesas de Selling	(18.855)	10,1%	(11.018)	10,1%	(7.837)	10,0%
Contingência	(2.204)	1,2%	(1.283)	1,2%	(922)	1,2%
IR e CSLL	(1.449)	0,8%	(846)	0,8%	(603)	0,8%
Lucro Imobiliário	38.551	20,6%	22.568	20,6%	15.982	20,5%

Pareceres

Análise da Mancha e Implantação

Prospecção

Operações

Incorporação

Inteligência de Mercado

Financeiro

Anexos

- **DESCRIÇÃO DOS IMÓVEIS:** Matrículas nºs 63.030 e 63.310 ambas do 18º Cartório de Registro de Imóveis da Comarca de São Paulo/SP. ("Imóveis"), localizados na Rua Leonel Martiniano, s/n, Cidade de São Paulo, Estado de São Paulo. Os Imóveis estão cadastrados perante a Municipalidade sob o nº 203.038.0013-3.

- **PROPRIETÁRIA TABULAR: EVOLVERE EMPREENDIMENTOS LTDA ("EVOLVERE")** com sede na Cidade de Barueri, Estado de São Paulo, na Alameda Tocantins, n.º 125, 32º andar, Conjunto 3202, Alphaville Industrial, CEP: 06455-020, inscrita no CNPJ sob o n.º 12.235.659/0001-06 sendo sócios **Jose Roberto Briguenti,** brasileiro, engenheiro, portador da cédula de identidade RG nº 59036643 e inscrito no CPF/ME sob o nº 446.298.188-04, residente e domiciliado à Alameda Apetubas, nº 416 D, Santana de Parnaíba/SP, CEP: 06540-060 e **Sabino Jose Muniz**, brasileiro, divorciado, engenheiro, , portador da carteira de identidade RG n.º 78230822 e inscrito no CPF sob n.º 279.297.608-04, residente e domiciliado à Alameda Nhambiquaras, nº 81 D, Santana de Parnaíba/SP, CEP: 06540-085;

- **TÍTULOS AQUISITIVOS**:
  a) Escritura Pública de Venda e Compra, lavrada em 3 de abril de 2024, pelo Oficial de Registro Civil das Pessoas Naturais e Tabelião de Notas do Distrito de Aldeia da Comarca de Barueri/SP, Livro 794, fls. 151/160, registrada sob nº R.11/M.63.030 e R.7/63.310, respectivamente, em 11/04/2024 em que **TERRAM ENGENHARIA DE INFRAESTRUTURA LTDA** vendeu os Imóveis para **EVOLVERE.**

- **CONSIDERAÇÕES JURÍDICAS SOBRE O IMÓVEL: (a) Retificação:** Estudos técnicos em andamento; **(b) Loteamento:** Due Diligence em andamento; **(c) Desmembramento:** Estudos técnicos em andamento; **DD IMÓVEL em andamento: (d) Área construída**: A certidão de dados cadastrais indica área construída de 2.630m², enquanto as matrículas não trazem informações referente construção; **(e) Débitos Imobiliários**: Negativa; **(f) Multas:** Negativa; **(g) Ônus e Gravames**: Da análise das visualizações das matrículas não constam ônus ou constrições; **(h) Ocupação:** *Due Diligence* em andamento; **(i) TAC**: Due Diligence em andamento; **(j) CONDEPHAAT, IPHAN:** *Due Diligence* em andamento; **(k) Desapropriação e Melhoramentos:** *Due Diligence* em andamento **(l) <u>Função Social da Propriedade</u>:** *Due Diligence* em andamento.

- **CONSIDERAÇÕES PRELIMINARES SOBRE A PROPRIETÁRIA E OS SÓCIOS DA PROPRIETÁRIA (DD em andamento):**

- **EVOLVERE EMPREENDIMENTOS LTDA:**

- Processo nº 1059580-95.2024.8.26.0100: Trata-se de ação de dissolução parcial da sociedade "SERRA TALHADA I ENERGIA SPE LTDA. – EM RECUPERAÇÃO JUDICIAL", no valor da causa de **R$ 30.000,00**, em que Evolvere é uma das autoras, a qual foi deferida a tutela de urgência determinando a dissolução parcial da empresa, contudo, a ação foi julgada extinta, sem resolução de mérito, para acolher a alegação de existência de convenção de arbitragem, tendo condenando as requerente ao pagamento das custas e despesas processuais, além de honorários advocatício fixados em 15% sobre o valor da causa. Aguarda-se o julgamento da Apelação.
- Não foi possível emitir a certidão negativa de débito Federal (DAU). Apesar de não termos recebido o extrato fiscal e-Cac para apurarmos o diagnostico fiscal, foi possível localizar um débito inscrito em dívida ativa no valor de **R$ 66.494,14** conforme consulta realizada no site do Regularize.
- Está pendente de apresentação a Certidão Conjunta de Débitos de Tributos Mobiliários do Município de Barueri/SP

- **JOSÉ ROBERTO BRIGUENTI:**

- Está pendente de apresentação a Certidão Conjunta de Débitos de Tributos Mobiliários do Município de Itatiba/SP
- Ações trabalhistas nºs 0010703-76.2015.5.15.0145, 0010975-70.2015.5.15.0145 e 0010805-98.2015.5.15.0145: tratam-se de ações trabalhistas as quais foram arquivadas definitivamente em 2015.
- Processos nºs 1504484-24.2017.8.26.0281 e 1505501-95.2017.8.26.0281: tratam-se de execução fiscal referente a cobrança de débito IPTU de imóvel diverso (BARUERI). Os processos estão suspensos tendo em vista os parcelamentos administrativos.

- **SABINO JOSÉ MUNIZ:**

- Está pendente de apresentação a Certidão Conjunta de Débitos de Tributos Mobiliários do Município de Santana de Parnaíba/SP, contudo, recebemos o extrato negativo de débito emitido pela secretária municipal de Itatiba
- Processo nº 0047822-82.2000.8.26.0002: Trata-se de embargos de terceiros no valor da causa de R$ 1.000,00, em que a única decisão disponível no site do TJSP é de 2006 determinando que se cumpra o acórdão. Os autos foram arquivados em 2006. Não foi possível localizar o processo principal.
- Processo nº 0832978-84.2006.8.26.0002: Trata-se de embargos à execução no valor da causa de R$ 9.394,71, em que não há qualquer andamento processual disponível no site do TJSP. Pelo processo principal, o mesmo foi arquivado provisoriamente em 2006, sem informação quanto aos embargos.

- **CONTINUAÇÃO - CONSIDERAÇÕES PRELIMINARES SOBRE A PROPRIETÁRIA E OS SÓCIOS DA PROPRIETÁRIA (DD em andamento):**

- **SABINO JOSÉ MUNIZ:**

- As ações abaixo indicadas são sem qualificação e podem se referir a homônimos, o que é provável, considerando o nome "comum" do pesquisado:
- Processo nº 0087851-75.1980.8.26.0100: Trata-se de ação cível em que não há qualquer andamento processual disponível no site do TJSP, consta apenas que os autos estão arquivados.
- Processo nº 0016399-28.2009.8.26.0281: Trata-se de execução fiscal referente a cobrança de IPTU, no valor da causa de R$ 13.894,77, em que não é possível verificar o imóvel. O processo está suspenso desde 2010 tendo em vista o parcelamento do débito. CDA inativa.
- Processo nº 0016473-82.2009.8.26.0281: Trata-se de execução fiscal, no valor da causa de R$ 3.102,57, em que não é possível verificar o objeto do débito. O processo está suspenso desde 2010 tendo em vista o parcelamento do débito. CDA inativa.

CONCLUSÃO:

- Em atenção aos apontamentos identificados até a conclusão deste parecer preliminar em nome da **PROPRIETÁRIA**, à exceção da verificação de débitos junto à Receita Federal em nome da proprietária no valor de **R$ 66.494,14,** o qual recomenda-se que seja quitado, e que apresente o extrato fiscal emitido via E-CAC, para que possa ser analisado se há outros débitos que estão impedindo a emissão da CND Federal.

- No mais , não foram identificados, até o momento apontamentos que onerem e coloque em risco o presente negócio.

PARECER PRÉVIO – Legalização

ÁREA DE IMPLANTAÇÃO

- O terreno composto por 2 matrículas:

Matrícula nº 63.030 – 18º RI, em nome de pessoa jurídica, que totaliza uma área escriturária de **5.480,00m²**;

Matrícula nº 63.310 – 18º RI, em nome de pessoa jurídica, que totaliza uma área escriturária de **5.728,00m²**;

- O cadastro do imóvel é urbano;
- O cenário 1 foi desenvolvido sobre a poligonal **12.557,58m² (área superior a soma das matrículas que correspondem a 11.208,00m² de terreno)**;
- Ficha Técnica (BDT) Informa duas DUPs: Lei nº 17.975/2023 | Decreto nº 63.188/2024 (Caducas)

DIRETRIZES URBANÍSTICAS

- O terreno está inserido em **ZEIS-1**, conforme **Decreto 63.728/2024** (Proporção: Mínimo: 60% HIS-1 | HIS-2 Permitido | HMP e outros usos máximo 20%)
- C.A. máximo: **2,5 para EZEIS**, sem restrição de **gabarito, T.O. 0,70%** e **PA 12**, necessário reserva de calçada;

Terreno não será parcelado (sem exigência de doação de áreas públicas);

A legislação não exige vaga de garagem, cenário considera 1 vaga PNE | Usos permitidos: EHIS e EHMP

O estudo considera dois condomínios, sendo:

IMPLANTAÇÃO

Condomínio 1: Total de 822 UH

CA máx + benef. Aplicáveis (5,75):

+ Cota Solidariedade = 10% + 20% = 0,75

+ 50% HIS 1 (toda cidade) = 1,25

+ 50% HIS 1 e HIS 2 = 1,25

C.A projetado Condomínio 1 = 5,49

Condomínio 2: Total de 972 UH

CA máx + benef. Aplicáveis (5,75):

+ Cota Solidariedade = 10% + 20% = 0,75

+ 50% HIS 1 (toda cidade) = 1,25

+ 50% HIS 1 e HIS 2 = 1,25

C.A projetado Condomínio 2 = 5,05

PARECER PRÉVIO – Legalização

AVALIAÇÕES AMBIENTAIS

Arbóreo

- Conforme mapa vegetação 1988 o terreno **não** é considerado como Patrimônio Ambiental e/ou Área de Proteção de Mananciais (APRM) e Unidade de Conservação;
- Para o cenário de comitê, conforme parametrização enviada, foi considerado 10% de incidência arbórea.

HIDROGRAFIA

- O Imóvel não apresenta corpos d'água no terreno;

AVALIAÇÕES AMBIENTAIS

Contaminação

- O terreno apresenta histórico de contaminação e, atualmente, é ocupado por uma empresa de terraplanagem que utiliza maquinários pesados, como tratores. No local, são realizadas atividades de manutenção mecânica e pintura desses equipamentos, práticas que podem potencialmente contaminar o solo. Dessa forma, recomenda-se o prosseguimento com a investigação.

OBS PROSPECÇÃO: Não foi prevista verba para remediação; contudo, o CVC estabelece que, em caso de confirmação de contaminação, poderemos antecipar o valor necessário e descontar 100% dos custos de remediação

ÓRGÃOS DE PATRIMÔNIO HISTÓRICO

- De acordo com a certidão CIT, o imóvel é isento de aprovação perante ao CONPRESP, CONDEPHAAT e IPHAN;

URBANIZAÇÃO

- Conforme croqui patrimonial, não consta área pública no imóvel;

PARECER PRÉVIO – Legalização

ZONEAMENTO

O terreno está localizado parcialmente em Macroárea de Estruturação Metropolitana, que permite a utilização dos incentivos previstos no artigo 60 do Plano Diretor Estratégico (PDE). Diante disso, incluímos no cronograma e no processo de licenciamento uma consulta técnica com o objetivo de obter melhor compreensão sobre a proporção dos incentivos aplicáveis ao terreno, em relação ao benefício de +50% de HIS1 e HIS2 segundo alínea "c" do artigo 60 do PDE.

Obrigado(a)