Tenda

sua próxima conquista

# Book Essencial de Investimento

Regional: SP – Zona Oeste

Projeto: Pirajussara

Data Comitê: 02/12/2025

# One Page – Pirajussara

| | | | |
|---|---|---|---|
| **Cidade** | São Paulo | **Mancha de demanda** | SP - SZO1 - São Paulo Oeste 1 |
| **Regional** | SP | **Cluster MPR** | 5 - Roxo |
| **Cenário de Aprovação** | Aprovação | **Tipo de Aprovação** | Consolidado |
| **Fase Anterior** | N/A | | |
| **Tipo de Comitê** | Essencial | **Versão da VF** | Versão 1.0: Nov |

| | | | |
|---|---|---|---|
| **Unidades (Fases)** | 1103 (2) | **CA Máx \| Proj** | 5,4 \| 3,0 |
| **Unidades com Vaga (%)** | 0 (0%) | **Escritura \| Lançamento** | nov/28 \| dez/28 |
| **Unidades com Varandas (%)** | 540 (49%) | **Tipologia** | F2E - Concreto |

| | | | |
|---|---|---|---|
| **Valor Líquido do Terreno (% VGV)** | 51.897 (17,0%) | **Un. Perm. Fís (% Ter)** | 0 (0,0%) |
| **Cash (Correção)** | 0 (N/A) | **%VGV Perm Fin Líquida (% Ter)** | 17,0% (100,0%) |
| **Valor R$/m²** | 4.474 | **VAR (%VGV)** | 000 (0,0%) |

| | | | |
|---|---|---|---|
| **Custo Construção (%VGV)** | 111.238 (36,4%) | **Indireto Unit.** | 19.730 |
| **Prazo da Obra (meses)** | 22 | **Torre Unit.** | 56.048 |
| **Custo Total Unit. \| Corrigido (LPU):** | 100.851 \| 101.319 (94) | **Infra Unit.** | 13.547 |
| **Início de Obra** | jun-29 | **Fundação Unit.** | 9.033 |

| | | | |
|---|---|---|---|
| **Preço Nominal Unit.** | 276.768 | **VSO** | 31 |
| **Preço Raso Unit.** | 260.917 | **Referência** | Vision |
| **Avaliação Unit.** | 299.691 | **Renda (% em RET 1%)** | 5.311 (0,9%) |

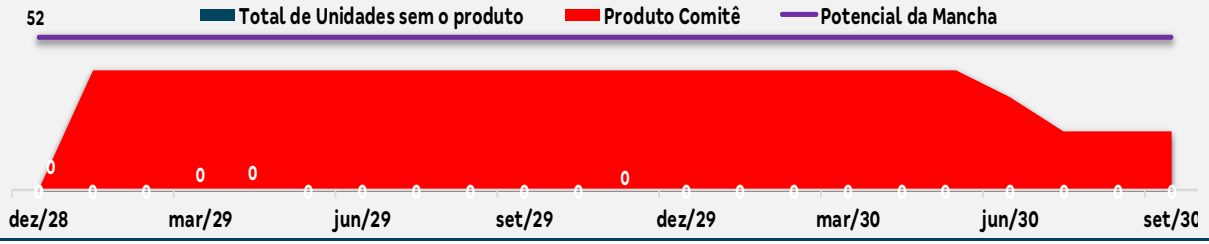


| | | | |
|---|---|---|---|
| **LI (Régua):** | **20,0% (20,0%)** | **Margem Bruta Econômica:** | 37,8% |
| **LI Resiliência:** | 13,2% (N/A) | **Margem Rasa Econômica:** | 33,5% |
| **Margem Bruta REF:** | 41,9% | **Margem Contribuição Econômica:** | 25,1% |
| **Margem Rasa REF:** | **38,4%** | **Exposição (% VGV):** | 13.544 (3,8%) |
| **TIR:** | 189,6% | **VGV Total:** | **305.275** |
| **Payback Contingente (21 m) :** | **18 m/ (-3 m)** | **Ger. Caixa 12 meses (R$):** | - |
| **Payback Consolidado:** | 18 | **Ger. Caixa 24 meses (R$):** | - |

## Destaques

**[1]** O Terreno de propriedade da Fibra Experts. Está localizado na Av. Pirajussara, 4359, na região do Butantã mancha ZO1 - Zona Oeste, bem próximo ao nosso Max Vila Sônia (vide slide 8). Região consolidada, com proximidade ao transporte público (A 400m da futura estação de metrô da linha amarela e em frente ao corredor de ônibus), shoppings, hospitais, escolas, serviços e lazer. O terreno possui área de 11.599 m²

**[2]** O projeto é composto por condomínio único, VGV de 305MM e um total de 1.103uh, divididas em 2 fases de lançamento, sendo que: (i) Fase 1 com 729 uh; (iI) Fase 2 com 374 uh; Zoneamento ZM com limitação de gabarito T+9, atingindo CA de 3,14x (58% - CA máx: 5,4); primeiro projeto em comitê assumindo a nova proposta técnica de geminação de torres – até termos uma confirmação dos custos da solução técnica, estamos assumindo acréscimo de 1K/unidade no custo de construção da folha rosto diretamente na viabilidade; projeto com 49% das unidades com varanda e 20 unidades de 1 dormitório nas pontas de 1 torre para ampliar adensamento;

**[3]** Condição Comercial: Permuta Financeira
- 100% Permuta Financeira: 17% de fração incidentes sobre o VGV bruto (sem descontos);
- Valor atual da VF: 51,8MM na permuta / PMG: 55MM corrigidos – correção referente a 50% do IPCA, com data base 6 meses do lançamento;
- Preço mínimo garantido para quitação em 12 meses do habite-se da última fase;
- **OBS:** Preço do terreno VF 51,8MM: R$ 1.422/CA e R$ 4.474/m2 / Preço terreno PMG 55MM R$ 1.510/CA e R$ 4.741/m2

**[4]** Condições Resolutivas:
a) *Etapa I: Em até 3 (três) meses para resolutivas técnicas, resolutivas jurídicas e financeira;
b) *Etapa II: 18 meses a contar a partir da superação da Etapa I, para aprovação de projeto, contratação CEF, análise técnica, financeira e comercial para o lançamento do empreendimento;

**OBS*:** Já é conhecimento da Tenda e alinhado com os vendedores pela due diligence prévia realizada, que os prazos serão suspensos/postergados em função do impedimento para entrada no imóvel previsto até jul/26, e que impactará também nos prazos das resolutivas da Etapa II; para a Tenda não há prejuízo pois o terreno tem PMG fixo e com correção somente após o lançamento – detalhamentos nos slides 14/ 15

**[5]** Projeto para aprovação no formato de **Comitê Essencial**, na régua de 20% LI, com baixa de 70% das unidades;

Pareceres

Análise da Mancha e Implantação

Prospecção

Operações

Incorporação

Inteligência de Mercado

Financeiro

Anexos

# Pareceres

| Área | Riscos Associados | Parecer | Flag |
|---|---|---|---|
| Jurídico Aquisição | Conforme a due diligence preliminar, existe (i) a alienação fiduciária do imóvel à True Securitizadora S/A, para garantia de 31% do valor total de R$ 100.000.000,00, devendo apresentar matrícula livre de ônus e gravames, em momento a ser previsto em contrato; (ii) os Débitos de IPTU inscritos no PPI sob nº 2.774.330-6, relativo aos exercícios de 2010 a 2014, sendo necessária apresentação de extrato, e sob nº 2.791.901-3, relativo ao exercício de 2015, em dívida ativa e no valor atualizado de R$ 270.860,41, devendo ocorrer o pagamento dos débitos previamente a outorga da escritura de venda e compra; e (iii) Ocupação: Escola Ítaca obteve a procedência em 2ª instância, nos pedidos renovatórios, o contrato de locação da área maior possuirá vigência até 31/12/2027 e da área menor (quadra esportiva) possuirá vigência até 01/06/2028, sendo determinado a realização de perícia técnica em liquidação de sentença, devendo ocorrer a devida Notificação do Inquilino sobre a venda do Imóvel com a obtenção da renúncia do direito de preferência e Distrato da Locação contendo a ratificação da renúncia ao direito de preferência na aquisição, nos termos das condições resolutivas do Compromisso de Compra e Venda firmado com a Proprietária Tabular. A visita ao imóvel está temporariamente impedida pelo efeito suspensivo da ação cominatória. Desta forma, conclui-se que, do ponto de vista jurídico, não há óbices para seguir com a presente transação, uma vez que em contrato constam os prazos para entrega de matrícula regularizada, quitação de débitos, e área com todos os trâmites de distrato/despejo ou desocupação, em condições resolutivas. | Ok com ressalvas | |
| Legalização | Os prazo do cronograma de comitê ampliado e lançamento só iniciarão após a liberação dos terrenos para efetivação dos estudos técnicos (Arbórel, Plani, ambiental, Sondagem, etc...) | Ok com ressalvas | |
| DPP | N/A | Ok | |
| Inteligência de Mercado | Preço Vision como factível | Ok | |
| Prospecção | Terreno de propriedade da incorporadora Fibra Experts que desistiu de seguir com o projeto em aprovação de médio padrão. Terreno foi a mercado para venda com propostas dos principais *big players* . Concorrentes fizeram propostas parceladas em 48x e estratégicamente, sugerimos uma parceria em permuta financeira, o que resultou em uma fração elevada, uma vez que nossa condição parcelada ficava ligeiramente abaixo dos concorrentes. Como ponto de atenção, destacam-se a autorização de entrada no imóvel pelo inquilino para realização dos estudos técnicos e a posterior desocupação, sendo ambos de responsabilidade do Vendedor e garantidos contratualmente. O não cumprimento dessas obrigações não acarretará riscos jurídicos ou financeiros para a empresa, apenas a suspensão do contrato. Seguiremos com a baixa de 70% no Comitê Essencial. | Ok | |
| Estudos Econômicos | N/A | Ok | |
| Comercial/Ciclo | Preço e VSO são viáveis | Ok | |

Pareceres

**Análise da Mancha e Implantação**

Prospecção

Operações

Incorporação

Inteligência de Mercado

Financeiro

Anexos

# Localização – Av. Pirajussara, 4359 – Vila Sônia – São Paulo - SP

USP

HOSPITAL

PREFEITURA DE SÃO PAULO

ESCOLA MUNICIPAL

MAX VILA SÔNIA

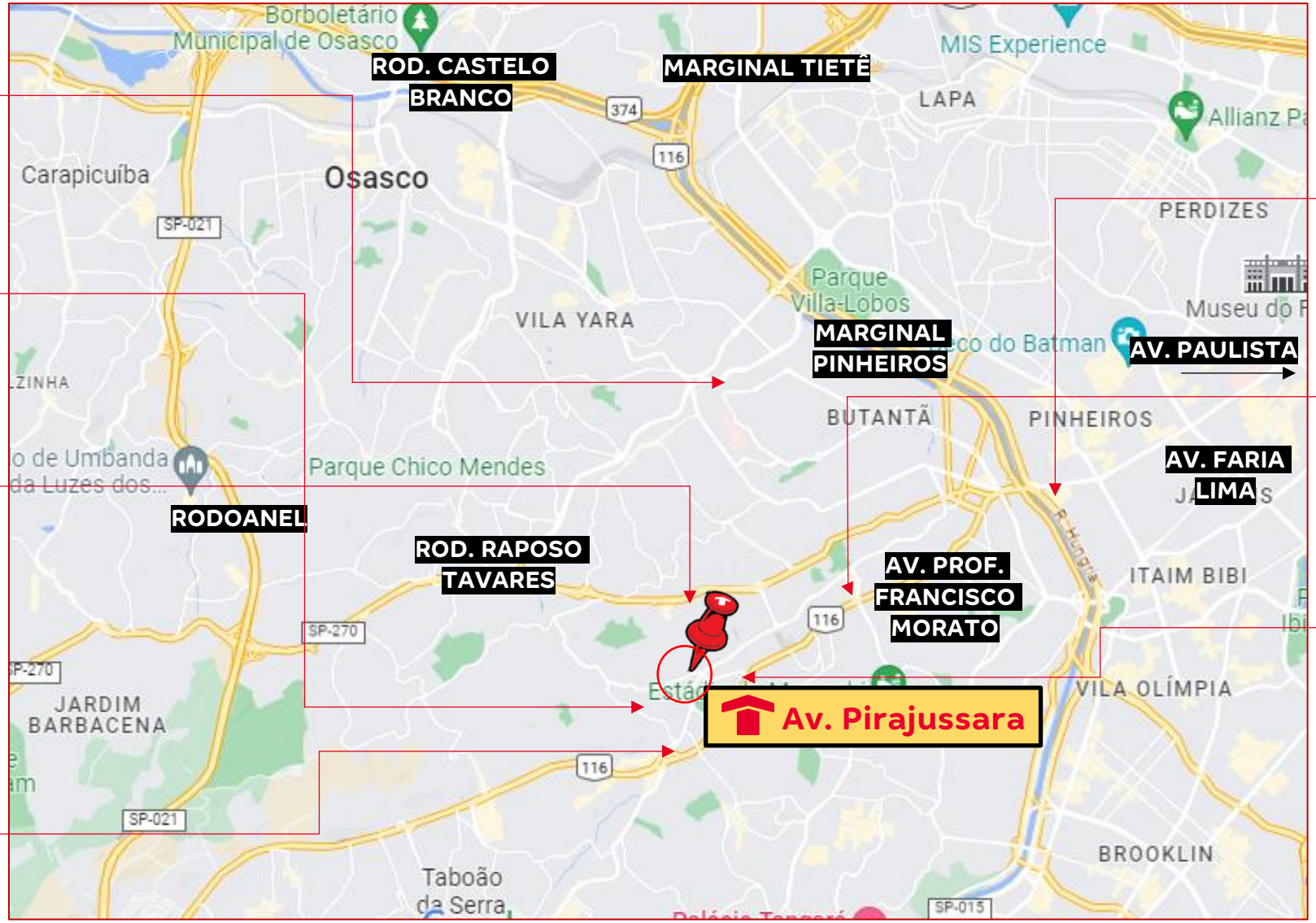

SHOPPING ELDORADO

SHOPPING BUTANTA

PARQUE CHACARA JOCKEY

# Localização – Av. Pirajussara, 4359 – Vila Sônia – São Paulo - SP

# Localização – Av. Pirajussara, 4359 – Vila Sônia – São Paulo - SP

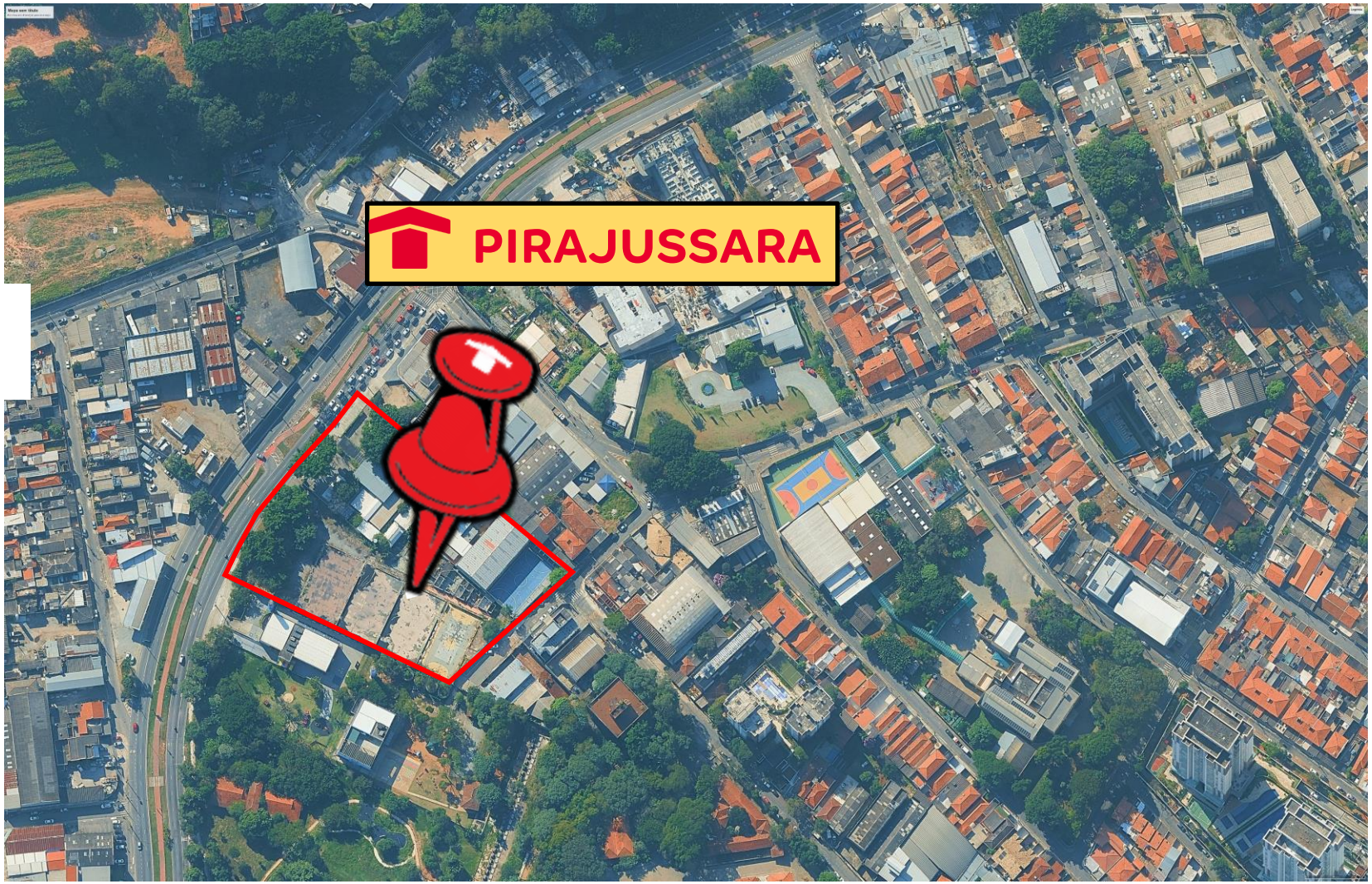




# Mancha de Demanda

**MANCHAS DE DEMANDA**

- SZO– São Paulo Oeste

Lançamento

1. Life Jaguaré
2. Max Vila Sônia

LandBank

3. Villa Butantã
4. Essence Butantã
5. Bosque | Paços Das Artes
6. Terrazo Butantã
7. Pirajussara

**Cluster MPR – (Comitê)**

- Cluster 5 - Roxo

**Região**

Capital

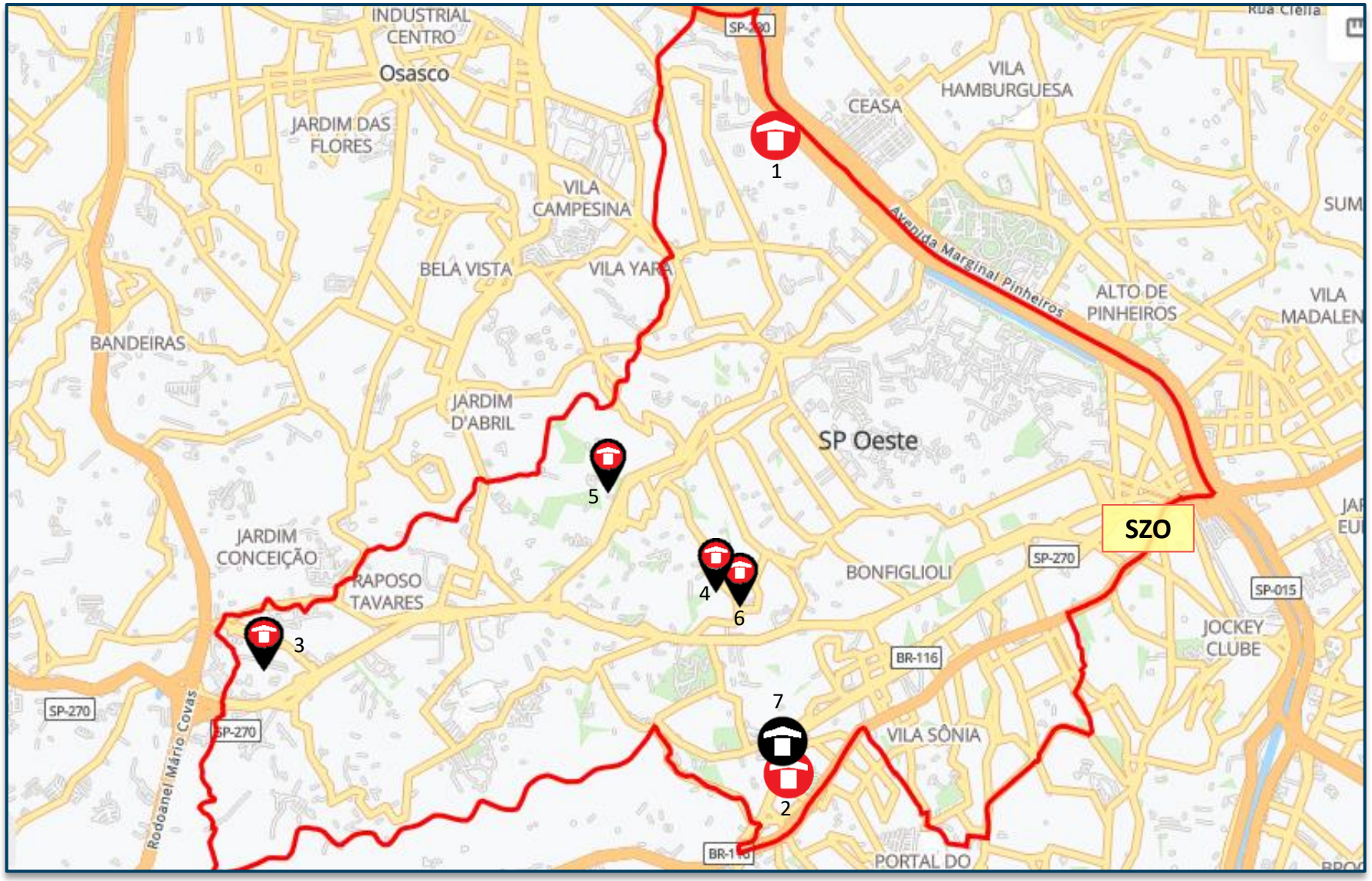


*Lançados* *LandBank* *Comitê*

# PRODUTO

## AV. Pirajussara – Comitê Essencial

| Informações Gerais – Condomínio Único | | | |
|---|---|---|---|
| Terreno | Área terreno | 11.598,32 m² | |
| | Reserva de calçada/ melhoramento viário | 634,23 m² | |
| | Menor poligonal | 11.123,14 m² | |
| | Área liquida | 11.123,14 m² | |
| | Zoneamento | ZM | |
| | CA máximo | 5,40 | ZONA: 3,00 |
| | | | INCENTIVO HIS: 1,50 |
| | | | COTA: 0,90 |
| | CA projetado | 3,14 | |
| | Gabarito máximo | T+9 | |
| Geral | Total UH | 1.103 | |
| | Total de vagas | 02 (1x PCD + 1 Idoso) | |
| Tipologia | Tipologia | V0200 | |
| | Gabarito | T+9 | |
| | Lâmina | 22PP + 12PP + 14PP | |
| | Área privativa | 31,84m² \| 33,59m² | |
| Condomínio | Unidade PCD | 34 | |
| | Unidade lazer \| técnica | 09 \| 08 | |
| | Torre | 08 | |
| | Fase | Duas fases | |
| Lazer | Lazer coberto | 2x Salão de Festas \| 5x Churrasqueira | |
| | Lazer descoberto projetado | Quadra, piscina, play kids, play baby, pet place, fitness | |

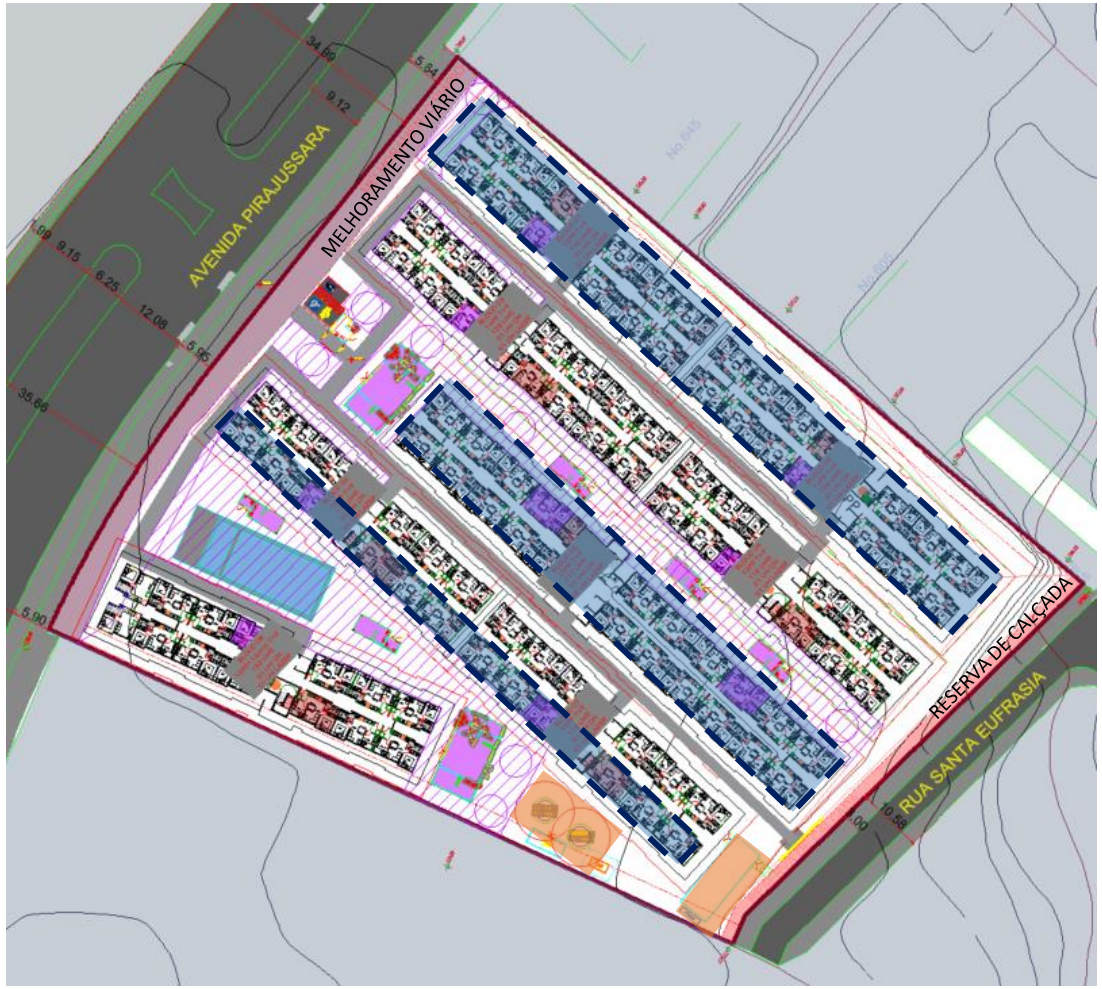


*Condomínio único com mais de 1.000UH, zero vagas*

LEGENDA:

- Área técnica
- Lazer
- Melhoramento Viário
- Faces com Varandas

**ESTUDO DE MASSA**

# PRODUTO

## AV. Pirajussara – Comitê Essencial

| | Descrição | Criticidade | Parecer |
|---|---|---|---|
| Usabilidade | **Acesso Empreendimento** | | |
| | **Percurso do pedestre até torre** | | |
| Diferencial produto | **Prime** | Sim | Faixa 3 |
| | **Supercondomínio** | Sim | Metrô + Armazenagem de Mensageria |
| | **Atributos Infra** | - | A definir |
| | **Atributos Torre** | - | 50% de varanda |
| | **Edifício Garagem** | Não | |

| | Considerações | Criticidade | Descrição |
|---|---|---|---|
| Material analisado | KMZ | | |
| | Matrícula | | |
| | Planialtimétrico | | |
| Projeto | Área líquida | | |
| | Drenagem | | |

# AV. Pirajussara – Comitê Essencial

| FASE 1 | | | FASE 2 | | | |
|---|---|---|---|---|---|---|
| HIS 2 - S/ varanda | HIS 2 - C/ varanda | R2v C/ varanda | HIS 2 - S/ varanda | HIS 2 - C/ varanda | R2v C/ varanda | HIS 2 - 1D S/ varanda |
| 297 | 287 | 145 | 246 | 34 | 74 | 20 |
| 41% | 39% | 20% | 66% | 9% | 20% | 5% |

| Consolidado | | | |
|---|---|---|---|
| HIS 2 - 1D S/ varanda | HIS 2 - S/ varanda | HIS 2 - C/ varanda | R2v C/ varanda |
| 20 | 543 | 321 | 219 |
| 51% | | 49% | |

| Categorias de uso | | |
|---|---|---|
| HIS 2 | 884 | 80% |
| R2v | 219 | 20% |
| | 1103 | |

Pareceres

Análise da Mancha e Implantação

Prospecção

Operações

Incorporação

Inteligência de Mercado

Financeiro

Anexos

# Condições do Negócio

- **PAGAMENTO DO TERRENO**
- Forma de pagamento: permuta financeira.
    - Valor do negócio (Viabilidade Financeira): R$ 51.896.763,00 -> R$ 1.422/CA e R$ 4.474/m2
    - Preço mínimo garantido: R$ 55.000.000,00 -> R$ 1.510/CA e R$ 4.741/m2
    - Valor do negócio (ECV + Contrato): R$ 52.000.000,00

- Permuta Financeira: 17% do VGV bruto, com carência inicial de 6 meses para o início dos repasses. Haverá compromisso de Pagamento Mínimo Garantido (PMG) correspondente aos 17%, com reajuste mensal após 6 meses contados do Lançamento do Empreendimento, pela variação acumulada de 50% do índice IPCA/IBGE. O prazo previsto para quitação será de até 12 (doze) meses a partir da emissão do "habite-se" da última fase do empreendimento. Em caso de saldo para atingimento do PMG reajustado, o respectivo saldo será parcelado em 6 parcelas mensais e sucessivas.

- **Obs:** Há uma condição especifica sobre o formato de correção do PMG. Além da consideração de correção por ½ inflação (IPCA), a dinâmica de reajuste será aplicada apenas sobre a fração de terreno (17%) das unidades ainda não comercializadas, ou seja, os repasses provenientes da fração de terreno da receita das unidades já vendidas, não incidirá correção. VF já considera ganho de preço, nenhum ajuste foi necessário.

- **ANTECIPAÇÃO DE DESPESAS**
- Não há previsão para antecipação;

- **GARANTIAS**

Para o Vendedor:

- Não há garantias, entretanto, caso os resultados financeiros divulgados pela Tenda estejam negativos, unicamente nessa hipótese ficará a critério da vendedora a opcionalidade pela escolha de um seguro permuta. Caso opte pela escolha da contratação do seguro garantia, o valor integral do seguro será descontado das parcelas vincendas da permuta financeira

- Data da escritura prevista: **Out/2028**

# Condições do Negócio

- **CORRETAGEM / INTERMEDIAÇÃO IMOBILIÁRIA**
- R$ 1.040.000,00 pagos em três parcelas mensais, iguais e sucessivas após ECV – equivalente a 2% do valor do CVC

- **PRAZOS CONTRATUAIS**
- Etapa I: Prazo 90 dias para resolutivas técnica, jurídica e financeira;
- Etapa II: Em até 18 meses após superação da Etapa I para aprovação do projeto, obtenção do financiamento CEF. viabilidade técnica e financeira, e outorga da ECV;
- **Obs: Todos os prazos contratuais estarão suspensos até o acesso ao imóvel pela Tenda para realização dos estudos técnicos**

- **CONDIÇÕES RESOLUTIVAS / DISTRATO**
- O CVC prevê cláusulas resolutivas específicas, que asseguram à Tenda o direito de prorrogar e rescindir o contrato a seu único e exclusivo critério. No caso de rescisão, a cláusula de saída será inviabilidade técnicas e financeira do empreendimento
- Procedimento de distrato: Decorrido o prazo informado acima (PRAZOS CONTRATUAIS), a TENDA deverá notificar os vendedores informando quanto a superação das condições resolutivas ou rescisão contratual sem penalidade para as partes

- **INFORMAÇÕES ADICIONAIS**
- O imóvel será entregue livre e desimpedido, e atualmente metade do imóvel está ocupado por uma escola, ao qual está em processo de despejo com previsão de desocupação para Jan/28.
- Há também uma impossibilidade de acesso para estudos técnicos sobre a área ocupada pela escola, ao qual o vendedor já ingressou com uma ação para acessar. Previsão de acesso: Jul/26.
- O cronograma do projeto está considerando inicio dos estudos em Jul/26 com previsão de baixa em até 120 dias desta data.
- O Imóvel é urbano e possui IPTU.
- Ficará a critério da Tenda avaliar se os estudos técnicos realizados pela Fibra são suficientes para antecipar o cronograma de licenciamento, porém isso não caracterizará superação das resolutivas, que se dará apenas após o acesso ao imóvel;

Pareceres

Análise da Mancha e Implantação

Prospecção

Operações

Incorporação

Inteligência de Mercado

Financeiro

Anexos

# Custo de Construção – SIMULADOR – FASE 1 DE COMERCIALIZAÇÃO

## ESTIMATIVA

| DADOS DA OBRA | | BASES | | PRAZOS DE OBRA | |
|---|---|---|---|---|---|
| Regional: | SP | Data: | novembro-25 | Pré Forma: | 5,4 meses |
| Endereço: | | Revisão: | R00 | Estrutura: | 7,5 meses |
| **Total de UH:** | **729** | LPU: | LPU 94 | Pós Forma: | 9,0 meses |
| Total Torres: | 3 | LVS: | agosto-25 | **TOTAL:** | **22,0 meses** |
| Produtos: | F2E Modular | INCC: | 1.216,706 | | |
| Tipologia: | MODULAR 10PP/16PP T+15 | | | Jogos de Formas: | 2 |
| | | | | Takt: | 2+2 |

## CUSTOS DE CONSTRUÇÃO

| | CUSTO | R$ / UND |
|---|---|---|
| **CUSTO TOTAL I** | **R$ 69.742.681** | **R$ 96.597** |
| INDIRETO | R$ 12.914.671 | R$ 17.887 |
| TORRE | R$ 40.453.842 | R$ 56.030 |
| INFRA | R$ 9.411.091 | R$ 13.035 |
| FUNDAÇÃO | R$ 6.519.739 | R$ 9.030 |
| ETE | R$ 0 | R$ 0 |
| EEE | R$ 0 | R$ 0 |
| CONTENÇÃO | R$ 51.453 | R$ 71 |
| TERRAPLENAGEM | R$ 391.885 | R$ 543 |
| **CUSTO TOTAL II** | **R$ 856.062** | **R$ 1.186** |
| VIÁRIO | R$ 172.018 | R$ 238 |
| DRENAGEM | R$ 0 | R$ 0 |
| EXTENSÃO ELÉTRICA | R$ 103.252 | R$ 143 |
| EXTENSÃO HIDRÁULICA | R$ 580.792 | R$ 804 |
| **CUSTO TOTAL I + II** | **R$ 70.598.742** | **R$ 97.782** |
| **CUSTO TOTAL III** | **R$ 0** | **R$ 0** |
| INCORRIDOS NÃO APROVEITADOS | R$ 0 | R$ 0 |
| **CUSTO TOTAL I A III** | **R$ 70.598.742** | **R$ 97.782** |
| **CUSTO TOTAL I A IV** | **R$ 70.598.742** | **R$ 97.782** |

## OBSERVAÇÕES GERAIS

**Parâmetro terraplenagem:** Nível 1
**Parâmetro Contenção:** Nível 1

## RATEIO FASEAMENTO

**% de Varanda:** 59%
**Possui Piscina:** Não
**ETE:** Não
**EEE:** Não

# Custo de Construção – SIMULADOR – FASE 2 DE COMERCIALIZAÇÃO

## ESTIMATIVA

| DADOS DA OBRA | | BASES | | PRAZOS DE OBRA | |
|---|---|---|---|---|---|
| Regional: | SP | Data: | novembro-25 | Pré Forma: | 5,4 meses |
| Endereço: | | Revisão: | R00 | Estrutura: | 3,9 meses |
| **Total de UH:** | **374** | LPU: | LPU 94 | Pós Forma: | 9,0 meses |
| Total Torres: | 3 | LVS: | agosto-25 | **TOTAL:** | **19,0 meses** |
| Produtos: | F2E Modular | INCC: | 1.216,706 | | |
| Tipologia: | MODULAR 10PP/16PP T+15 | | | Jogos de Formas: | 2 |
| | | | | Takt: | 2+2 |

## CUSTOS DE CONSTRUÇÃO

| | CUSTO | R$ / UND |
|---|---|---|
| **CUSTO TOTAL I** | **R$ 38.333.885** | **R$ 103.605** |
| INDIRETO | R$ 8.629.307 | R$ 23.322 |
| TORRE | R$ 20.750.924 | R$ 56.084 |
| INFRA | R$ 5.381.377 | R$ 14.544 |
| FUNDAÇÃO | R$ 3.344.832 | R$ 9.040 |
| ETE | R$ 0 | R$ 0 |
| EEE | R$ 0 | R$ 0 |
| CONTENÇÃO | R$ 26.397 | R$ 71 |
| TERRAPLENAGEM | R$ 201.049 | R$ 543 |
| **CUSTO TOTAL II** | **R$ 103.252** | **R$ 279** |
| VIÁRIO | R$ 0 | R$ 0 |
| DRENAGEM | R$ 0 | R$ 0 |
| EXTENSÃO ELÉTRICA | R$ 103.252 | R$ 279 |
| EXTENSÃO HIDRÁULICA | R$ 0 | R$ 0 |
| **CUSTO TOTAL I + II** | **R$ 38.437.137** | **R$ 103.884** |
| **CUSTO TOTAL III** | **R$ 0** | **R$ 0** |
| INCORRIDOS NÃO APROVEITADOS | R$ 0 | R$ 0 |
| **CUSTO TOTAL I A III** | **R$ 38.437.137** | **R$ 103.884** |
| **CUSTO TOTAL I A IV** | **R$ 38.437.137** | **R$ 103.884** |

## OBSERVAÇÕES GERAIS

**Parâmetro terraplenagem:** Nível 1
**Parâmetro Contenção:** Nível 1

## RATEIO FASEAMENTO

**% de Varanda:** 29%
**Possui Piscina:** Sim
**ETE:** Não
**EEE:** Não

Pareceres

Análise da Mancha e Implantação

Prospecção

Operações

Incorporação

Inteligência de Mercado

Financeiro

Anexos

# AMBIENTAL + LEGALIZAÇÃO – Paramétrico de custos

Tenda

## REGIONAL SP

PARAMÉTRICO DE CUSTOS LEGALIZAÇÃO

| DADOS | | QUANDO APLICAR |
|---|---|---|
| **Quantidade de unidades** | 1.103 | |
| **O Empreendimento terá R2V?** | SIM | |
| **Qual a área do Terreno?** | 11.599 | |
| **Quanto % do terreno Possui árvore?** | 5% | Se possivel contas arvores, considerar 6m² X quantidade de arvores / area do terreno. Caso não seja possivel, estimar por poligonal |
| **Possível Área Contaminada?** | SIM | Terrenos com histórico de uso industrial anterior; Os vizinhos do entorno podem possuem uso geradores de contaminantes (posto de gasolina, fabricas, gasodutos, etc...); |
| **Esta Cadastrado como Área Possivelmente Contaminada nos Orgão Publicos?** | NÃO | Quando no GEOSAMPA estiver classificado como área possivelmente contaminada |
| **Parcelamento do Solo?** | NÃO | |
| **Quantos Condomínios?** | 1 | Incluir a quantidade de condomínios que serão gerados no licenciamento |

| ABERTURA | $ FINAL | MÉTRICA |
|---|---|---|
| **Compensação Ambiental** | R$ 640.739 | média histórica/ m² de terreno + acrescimo de 30% do valor com aplicação de R2V |
| **Laudos, EIV, EIARIMA** | R$ 15.000 | 15k fixo |
| **Emolumentos e Taxas** | R$ 35.000 | 5k - Revalidação de Certidões + 30k aprovação CETESB (contaminação) quando for classificado como potencialmente contaminado ou existir a possibilidade de ter contaminação; |
| **Assessorias** | R$ 5.000 | Custas second opinion Ambiental |
| **Cópias, Plotagens, Autenticações, etc...** | R$ 15.000 | 15k fixo |
| **Contra Partida** | R$ 772.639 | Não temos contrapartida para SP Capital<br>Considerado custas de contaminação/ remediação histórica dos empreendimentos em LB/ m² de terreno |
| **Projeto de criação e Legal** | R$ 14.000 | 1.5k/condomínio de tercerização PL + 4k/condomínio de NBR + 5k complemento plani + 15k para parcelamento do solo (quando houver) + 3.5k para pl grapro (quando houver) |
| **Total** | **R$ 1.497.378** | **R$ 1358/uh** |

## CRITÉRIOS DE INPUT DO SIMULADOR

- Projeto SEM desmembramento
- Projeto sem doação de área verde ou institucional;
- Empreendimento com 19,86% em R2v, e 80,14 em HIS-2, sendo 20 delas com a tipologia de 1 Dorm.
- Previsto uma verba de R$ 750k para demolição;
- Não foi prevista verba para remediação; contudo, o CVC estabelece que, em caso de confirmação de contaminação, poderemos antecipar o valor necessário e descontar até 1 milhão dos custos de remediação.

# JURÍDICO – Paramétrico de custos

## REGIONAL SP

PARAMÉTRICO DE CUSTOS JURÍDICO IMOBILIÁRIO

| DADOS | | QUANDO APLICAR |
|---|---|---|
| **Quantidade Unidades** | 1.103 | |
| **Área Construída** | 43.844 m² | |
| **Tem SQL?** | SIM | |
| **Valor do carne de IPTU** | R$ 325.459 | Considerar sempre o valor do caner de IPTU do ano de aplicação |
| **Área de Matrícula** | 11.599 | |
| **Retificação?** | NÃO | Quando a matrícula não tiver o encerramento descrito e/ou detalhamento dos perímetro;<br>Quando houver necessária de de acrescimo ou exclusão de áreas do real para implantação do empreendimento; |
| **Quantos Condomínios?** | 1 | |
| **Quantos Proprietários de terreno?** | 1 | |
| **Parcelamento do Solo?** | NÃO | C/ Doação: Quando matrícula tiver mais de 20.000m² ou for necessário abertura de mais lotes |
| **Remembramento de Matrículas?** | NÃO | Quando a composição do empreendimento é composta por 2 ou mais matrículas para incorporar; |
| **Com qual valor o terreno será escriturado?** | R$ 52.000.000 | |

| ABERTURA | $ FINAL | MÉTRICA |
|---|---|---|
| **Desdobro de IPTU** | R$ 2.500 | R$ 2.5k/ condomínio |
| **Instituição de Condomínio** | R$ 1.378.750 | R$ 1250/uh |
| **Averbação da Construção** | R$ 331.463 | Área Construída(m²) X 4 meses de Cobrança X Índice Histórico (atual 1,79/m²) |
| **Procuração Societária** | R$ 5.000 | 5k fixo |
| **IPTU (Anual)** | R$ 325.459 | Valor do caner vigente de IPTU ou em caso de não tenha IPTU, considerado para calculo área da matrícula X Índice Histórico (atual 1,79/m²) |
| **Registro de Incorporação** | R$ 231.630 | R$ 210/uh + 40k quando houver necessidade de retificação |
| **Honorário Incorporação** | R$ - | Não gastamos mais com honorários de incorporação<br>Considerado IPTU Retroativo por não ter SQL: $ IPTU X 5 anos |
| **Cópias e Autenticações** | R$ 15.000 | 15k fixo |
| **Honorário Aquisição** | R$ 80.000 | 120k - 2 ou mais prorietários do terreno<br>80k - 1 proprietário do terreno |
| **Registro de Escritura** | R$ 390.000 | Valor do terreno X 0,75% |
| **ITBI Terreno** | R$ 1.560.000 | Valor do terreno X 3% |
| **Total** | **R$ 4.319.802** | **R$ 3.916/uh** |

# CRONOGRAMA PRÉVIO

**APROVAÇÃO DE CONDOMÍNIO**
TERRENO <20.000 - PROCESSO ORDINÁRIO
ANÁLISE GRAPROHAB > 800UH
COM ÁREA CONTAMINADA
COM CEUSO
IPHAN - Ñ SE APLICA
SEM RETIFICAÇÃO

**PRAZO**
28 meses

CIE — CIA — C — L

| MÊS | RESP | ETAPA | STATUS/ PRAZO (dias) | 0 | 1 | 2 | 3 | 4 | 5 | 6 | 7 | 8 | 9 | 10 | 11 | 12 | 13 | 14 | 15 | 16 | 17 | 18 | 19 | 20 | 21 | 22 | 23 | 24 | 25 | 26 | 27 | 28 | 29 | 30 | 31 | 32 |
|---|---|---|---|---|---|---|---|---|---|---|---|---|---|---|---|---|---|---|---|---|---|---|---|---|---|---|---|---|---|---|---|---|---|---|---|---|
| 0 | PROSP | COMITÊ INVESTIMENTO ESSENCIAL | - | | | | | | | | | | | | | | | | | | | | | | | | | | | | | | | | | |
| | NEG | REUNIÃO PASSAGEM/ PARTIDA | - | | | | | | | | | | | | | | | | | | | | | | | | | | | | | | | | | |
| | NEG | PLANIALTIMÉTRICO | 45 | | | | | | | | | | | | | | | | | | | | | | | | | | | | | | | | | |
| | NEG | DIRETRIZ SABESP | 45 | | | | | | | | | | | | | | | | | | | | | | | | | | | | | | | | | |
| | PRÉ-LEG | INVESTIGAÇÃO AMBIENTAL | 120 | | | | | | | | | | | | | | | | | | | | | | | | | | | | | | | | | |
| | DPP | ELABORAÇÃO AP | 30 | | | | | | | | | | | | | | | | | | | | | | | | | | | | | | | | | |
| | CUSTOS | PARAMETRIZAÇÃO | 20 | | | | | | | | | | | | | | | | | | | | | | | | | | | | | | | | | |
| | NEG | CONFIRMAÇÃO FINANCEIRA | 10 | | | | | | | | | | | | | | | | | | | | | | | | | | | | | | | | | |
| 6 | NEG | COMITÊ INVESTIMENTO AMPLIADO | - | | | | | | | | | | | | | | | | | | | | | | | | | | | | | | | | | |
| | GETEC | ENGENHARIA SIMULTÂNEA | 45 | | | | | | | | | | | | | | | | | | | | | | | | | | | | | | | | | |
| | GETEC | ELABORAÇÃO PROJETO SABESP | 30 | | | | | | | | | | | | | | | | | | | | | | | | | | | | | | | | | |
| | GETEC | APROVAÇÃO SABESP | 120 | | | | | | | | | | | | | | | | | | | | | | | | | | | | | | | | | |
| | GETEC | EP KIT LEGAL | 126 | | | | | | | | | | | | | | | | | | | | | | | | | | | | | | | | | |
| | PL | ELABORAÇÃO PL | 45 | | | | | | | | | | | | | | | | | | | | | | | | | | | | | | | | | |
| | LEG | CETESB (POTENCIAL CONTAMINADO) | 180 | | | | | | | | | | | | | | | | | | | | | | | | | | | | | | | | | |
| | LEG | CEUSO - NÍVEL DE ÁGUA | 365 | | | | | | | | | | | | | | | | | | | | | | | | | | | | | | | | | |
| | LEG | ALVARÁ DE APROVAÇÃO E EXECUÇÃO | 365 | | | | | | | | | | | | | | | | | | | | | | | | | | | | | | | | | |
| | LEG | APROVAÇÃO DE GRAPROHAB | 180 | | | | | | | | | | | | | | | | | | | | | | | | | | | | | | | | | |
| 24 | NEG | COMITÊ DE ESCRITURA/ LANÇAMENTO | - | | | | | | | | | | | | | | | | | | | | | | | | | | | | | | | | | |
| | JRI | ESCRITURA | 30 | | | | | | | | | | | | | | | | | | | | | | | | | | | | | | | | | |
| | JRI | REGISTRO INCORPORAÇÃO | 30 | | | | | | | | | | | | | | | | | | | | | | | | | | | | | | | | | |
| | CRD | LAUDOS CEF | 90 | | | | | | | | | | | | | | | | | | | | | | | | | | | | | | | | | |
| 28 | NEG | LANÇAMENTO | - | | | | | | | | | | | | | | | | | | | | | | | | | | | | | | | | | |
| | | | | | | | | | | | | | | | | | | | | | | | | | | | | | | | | | | | | |

PRAZO PARA SUPERAÇÃO 1ª ETAPA DE RESOLUTIVAS E PARA APROVAÇÃO DO COMITÊ AMPLIADO: até **nov/27**

Pareceres

Análise da Mancha e Implantação

Prospecção

Operações

Incorporação

Inteligência de Mercado

Financeiro

Anexos

# Demanda e Distribuição da Mancha

| Potencial de Demanda | | | Lançados | | Lanç + Landbank | |
|---|---|---|---|---|---|---|
| Mancha | CÓD. | Shr. | ANO | MÊS | ANO | MÊS |
| São Paulo Oeste | SZO | 36% | 520 | 43 | 624 | 52 |

| Faixas MCMV | Empreendimento | Renda | Lançamento | dez/28 | jan/29 | fev/29 | mar/29 | abr/29 | mai/29 | jun/29 | jul/29 | ago/29 | set/29 | out/29 | nov/29 | dez/29 | jan/30 | fev/30 | mar/30 | abr/30 | mai/30 | jun/30 | jul/30 | ago/30 | set/30 |
|---|---|---|---|---|---|---|---|---|---|---|---|---|---|---|---|---|---|---|---|---|---|---|---|---|---|
| Faixa 3 | Pirajussara - F1 | 5.014 | dez-28 | | 41 | 41 | 41 | 41 | 41 | 41 | 41 | 41 | 41 | 41 | 41 | 41 | 41 | 41 | 41 | 41 | 41 | 32 | | | |
| Faixa 3 | Pirajussara - F2 | 5.014 | jun-30 | | | | | | | | | | | | | | | | | | | | 21 | 21 | 21 |
| Total de Vendas Lançados | | | | 0 | 0 | 0 | 0 | 0 | 0 | 0 | 0 | 0 | 0 | 0 | 0 | 0 | 0 | 0 | 0 | 0 | 0 | 0 | 0 | 0 | 0 |
| Total de Vendas Lançados + Landbank | | | | 0 | 41 | 41 | 41 | 41 | 41 | 41 | 41 | 41 | 41 | 41 | 41 | 41 | 41 | 41 | 41 | 41 | 41 | 32 | 21 | 21 | 21 |
| *Total Mancha \| Faixa 1* | | | | | *0%* | *0%* | *0%* | *0%* | *0%* | *0%* | *0%* | *0%* | *0%* | *0%* | *0%* | *0%* | *0%* | *0%* | *0%* | *0%* | *0%* | *0%* | *0%* | *0%* | *0%* |
| *Total Mancha \| Faixa 2* | | | | | *0%* | *0%* | *0%* | *0%* | *0%* | *0%* | *0%* | *0%* | *0%* | *0%* | *0%* | *0%* | *0%* | *0%* | *0%* | *0%* | *0%* | *0%* | *0%* | *0%* | *0%* |
| *Total Mancha \| Faixa 3* | | | | | *100%* | *100%* | *100%* | *100%* | *100%* | *100%* | *100%* | *100%* | *100%* | *100%* | *100%* | *100%* | *100%* | *100%* | *100%* | *100%* | *100%* | *100%* | *100%* | *100%* | *100%* |

**Parecer de I.M sobre a mancha:**

O projeto analisado em comitê está em linha com o potencial teórico de demanda calculado para a mancha. (Total Lanç + Landbank)

**Canibalização:**

Sem Risco de Canibalização

# Pirajussara | Mapa Concorrência

| | | Pirajussara | Home Park Chácara Jockey | Singular Butantã | Pin Estação Vila Sônia |
|---|---|---|---|---|---|
| | | TENDA | Casa Viva | Cury | NeoUrb |
| | Distância Tenda (km) | | 200m | 3,8Km | 1,63Km |
| Região 1 Km | População | 43.561 | 40.465 | 39.813 | 26.563 |
| | Dens. Demográfica | 13.955 | 12.964 | 12.755 | 8.510 |
| | Renda (R$) | 7.545 | 8.062 | 10.871 | 16.437 |
| | Classe Social | B2 (de R$ 5.4K a 9.8K) | B2 (de R$ 5.4K a 9.8K) | B1 (de R$ 9.8K a 19.7K) | B1 (de R$ 9.8K a 19.7K) |
| | PEA Dia | 27.226 | 28.441 | 23.762 | 26.064 |
| Quantitativo | Lançamento | dez/28 | 06/2025 | 07/2025 | 09/2025 |
| | Unidades | 729 | 193 | 957 | 479 |
| | Estoque | 729 | 61 | 231 | 235 |
| | VSO | 41 | 33 | 182 | 122 |
| | Stockout | 18 | 2 | 1 | 2 |
| Qualitativo | Condomínios | 1 | 1 | 1 | 1 |
| | Torres | - | 1 | 3 | 2 |
| | Gabarito | T+9 | T+20 | T+14 | T+29 |
| | Plantas (m²) | 32m² e 33m² | 36m² e 42m² | 32m² e 38m² e 0 | 17m² e 28m² e 32,1m² e 35m² |
| | Tipologia | 2 Dorms | 2 Dorms | 2 Dorms | 1 e 2 Dorms |
| | Opções | Não | Não | Não | Não |
| | Varanda | Sim | Sim | Não | Não |
| | Vagas | Sem vaga | Sem Vaga | 6% de Vagas | Sem Vaga |
| | Lazer | Piscina, Churrasqueira, Salão de Festas, Brinquedoteca, Espaço Office, Espaço Fitness, Espaço Saúde, Espaço Teen, Praça de Convívio, Fitness Externo, Playpet e Bicicletário. | Tem Sacada, Bicicletário, Brinquedoteca, Espaço Gourmet, Fitness Center, Lavabo, Lavanderia, Lounge, Mercado, Pet Place, Piscina, Piscina infantil, Playground, Praça, Sacada, Salão de Festas, | Brinquedoteca, Coworking, Espaço delivery, Espaço Gourmet, Lavanderia, Piscina, Playground, Quadra Poliesportiva, Salão de Festas, Salão de Jogos, | Piscina, PlayPet, PlayBaby, Fitness, Salão de Festas, Academia, Bicicletário, Mini Market, Lavanderia, Espaço Office, Sala de Jogos, Roftop, Sauna e Fireplace. |

## Diagnóstico Concorrência

- As unidades HMP – Sem Varanda do projeto Tenda está competindo com as unidades da Cury na mesma tipologia, entretanto, além de estar melhor localizado, a Tenda já atua na região com o Máx Vila Sônia e tem conseguido atingir os preços estimados pelo Vision.
- Os demais concorrentes mapeamentos na região atuam em um target de preço acima do estimado para o Pirajussara.

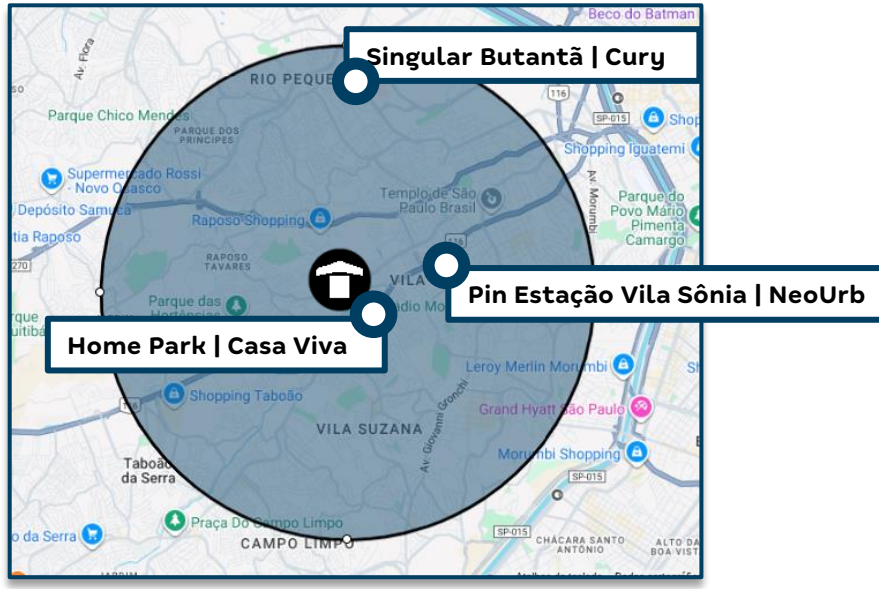


| Farol Renda |
|---|
| Acima de 300 |
| Entre 0 e 300 |
| Abaixo de 0 |

| - | Pirajussara | | | | | Home Park Chácara Jockey | | | | | Singular Butantã | | | | | | Pin Estação Vila Sônia | | | | |
|---|---|---|---|---|---|---|---|---|---|---|---|---|---|---|---|---|---|---|---|---|---|
| Tipologias | Avaliação | Preço Nominal | CEF | Renda | % Unidades | Preço Nominal | CEF | Renda | Dif | Farol | Avaliação | Preço Nominal | CEF | Renda | Dif | Farol | Preço Nominal | CEF | Renda | Dif | Farol |
| HMP - 1 Dorm | - | - | - | - | - | - | - | - | - | - | - | - | - | - | - | - | 275.777 | 220.622 | 5.300 | - | - |
| HMP | 293.000 | 257.682 | 201.273 | 4.500 | 41% | 324.000 | 259.200 | 6.300 | 1.800 | ● | 328.000 | 257.320 | 205.856 | 4.600 | 100 | ● | - | - | - | - | - |
| HMP - Varanda | 309.000 | 281.214 | 219.633 | 5.300 | 39% | - | - | - | - | - | 354.000 | 292.639 | 234.111 | 5.700 | 400 | ● | - | - | - | - | - |
| R2V - Varanda | 309.000 | 288.596 | 226.099 | 5.500 | 20% | 459.000 | 367.200 | 8.600 | 3.100 | ● | 354.000 | 307.775 | 246.220 | 6.000 | 500 | ● | 317.009 | 253.607 | 6.200 | 700 | ● |
| R2V - Varanda + Vaga | - | - | - | - | - | - | - | - | - | - | 395.000 | 353.185 | 282.548 | 6.900 | - | - | - | - | - | - | - |

# Simulação de Preço

## Informações Viabilidade

| Projeto: | Pirajussara | | | | | |
|---|---|---|---|---|---|---|
| **Tipo:** | **HMP** | | **HMP - Varanda** | | **R2V - Varanda** | |
| Método | **Vision** | | **Vision** | | **Vision** | |
| Avaliação | 293.000 | | 309.000 | | 309.000 | |
| Renda Inicial (VF) | 5.051 | | 5.590 | | 5.763 | |
| Renda Final* | 4.500 | | 5.300 | | 5.500 | |
| % RET1 | 0% | | 0% | | 0% | |
| **Tipo:** | **VF** | **R$** | **VF** | **R$** | **VF** | **R$** |
| Ato | 0,99 | 4.882 | 1,01 | 5.541 | 0,90 | 5.057 |
| FGTS | 0,99 | 4.873 | 0,96 | 5.252 | 0,87 | 4.872 |
| Financiamento | 96,62% | 196.401 | 95,84% | 214.381 | 96,15% | 221.228 |
| Subsídio | 0,00% | 0 | 0,00% | 0 | 0,00% | 0 |
| Prazo de Pró-soluto | 27 | 27 | 27 | 27 | 27 | 27 |
| Pró-Soluto | 76,17% | 37.743 | 72,19% | 39.589 | 71,10% | 40.196 |
| Preço Raso (RS) | 243.898 | 243.898 | 264.762 | 264.762 | 271.352 | 271.352 |
| TCD | 27,07% | 13.784 | 29,20% | 16.452 | 29,69% | 17.244 |
| VSO | 17 | 17 | 16 | 16 | 8 | 8 |
| Preço de Venda | **263.788** | **263.788** | **287.878** | **287.878** | **295.435** | **295.435** |
| Elasticidade | -2,315% | -2,315% | -2,315% | -2,315% | -2,315% | -2,315% |
| Preço de Venda Final | **257.682** | **257.682** | **281.214** | **281.214** | **288.596** | **288.596** |
| Preço Raso (R$) | **243.898** | | **264.762** | | **271.352** | |
| % de Raso | **94,65%** | | **94,15%** | | **94,02%** | |
| BP25 - Não Inflacionado | - | | - | | - | |
| BP25 - Inflacionado | - | | - | | - | |

# Análise de Preço

## Informações Viabilidade

| Projeto: | Pirajussara |
|---|---|
| **Tipo:** | **Faixa 2** |
| Método | **Vision** |
| Avaliação | 302.481 |
| Renda Inicial (VF) | 5.405 |
| Renda Final* | 5.014 |

| Tipo: | VF | R$ |
|---|---|---|
| Ato | 0,98 | 5.176 |
| FGTS | 0,95 | 5.022 |
| Financiamento | 96,22% | 208.418 |
| Subsídio | 0,00% | 0 |
| Prazo de Pró-soluto | 27 | 27 |
| Pró-Soluto | 73,60% | 38.957 |
| Preço Raso (RS) | 257.573 | 257.573 |
| TCD | 28,43% | 15.523 |
| VSO | 41 | 41 |
| Preço de Venda | **279.417** | **279.417** |
| Elasticidade | -2,315% | -2,315% |
| Preço de Venda Final | **273.095** | **273.095** |
| Preço Raso (R$) | **257.573** | |
| % de Raso | **94,32%** | |
| Raso Todas as Fases | **260.917** | |
| Nominal Todas as Fases | **276.768** | |

1

| Análise de Riscos | Farol IM |
|---|---|
| IM avalia o Preço Vision como **factível**. | |

1) I.M está de acordo com o preço Vision, o Pirajussara está localizado em uma ótima região, próximo ao recém-lançado Máx Vila Sônia, que apesar de ainda não ter um mês fechado de vendas, já tem performado o preço estimado pelo Vision no parecer, vide tabela abaixo.

Além disso, conforme consta no slide "Panorama de Concorrência", os concorrentes da região vendem em um target de preço e renda acima do previsto para o Produto Tenda.

| | | | Preço Real | | | Preço Norm. (27m) | |
|---|---|---|---|---|---|---|---|
| | Avaliação | Preço Raso | Renda Mediana | VSO | PSOL | Δ PSOL | Preço Raso |
| Dália | 244.715 | 220.929 | 3.113 | 22 | 35 | -8.149 | 212.779 |
| Vista Vila Das Belezas | 258.526 | 227.022 | 4.028 | 26 | 21 | 5.378 | 232.400 |
| Pirajussara | 302.481 | 257.573 | 5.014 | 41 | 27 | 0 | 257.573 |
| Máx Vila Sônia* | 299.734 | 263.040 | 5.000 | 61 | 32 | -7.207 | 255.833 |

*Resultado parcial de vendas.

# Resumo de Preços

## Vision

| Nome Fase | Tipologia | Renda | Ato | FGTS | Cond. | Subsídio | PSOL | TCD | VSO | Nom. Pré | Avali. | Elast. | Nom. Pós | Raso Pós | PSOL (m) | RET1 |
|---|---|---|---|---|---|---|---|---|---|---|---|---|---|---|---|---|
| Pirajussara - F2 | HMP | 5.051 | 0,99 | 0,99 | 97,5% | 0,0% | 83,4% | 29,6% | 14 | 259.495 | 293.000 | 6,9444% | 277.516 | 262.425 | 24 | 0% |
| Pirajussara - F2 | HMP - Varanda | 5.590 | 1,01 | 0,96 | 97,0% | 0,0% | 79,0% | 32,0% | 2 | 283.375 | 309.000 | 6,9444% | 303.054 | 285.043 | 24 | 0% |
| Pirajussara - F2 | R2V - Varanda | 5.763 | 0,90 | 0,87 | 97,4% | 0,0% | 77,8% | 32,5% | 4 | 290.863 | 309.000 | 6,9444% | 311.062 | 292.183 | 24 | 0% |
| Pirajussara - F2 | HMP - 1 Dorm | 2.916 | 0,81 | 0,91 | 93,3% | 108,0% | 92,6% | 75,9% | 1 | 214.949 | 230.000 | 6,9444% | 229.876 | 207.552 | 24 | 50% |

# Ciclo Financeiro – Análise Mancha

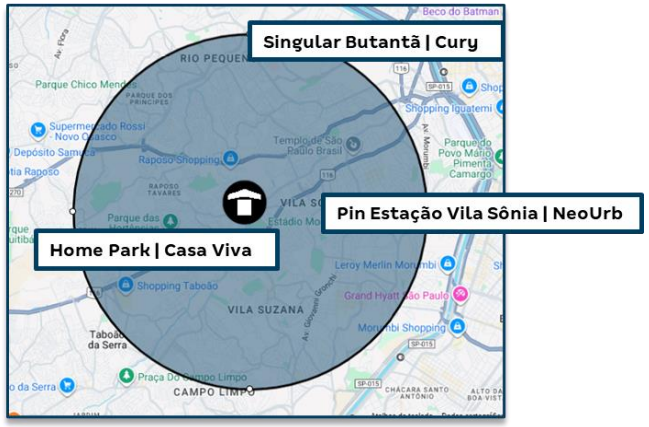


| - | Pirajussara | | | | | Home Park Chácara Jockey | | | | | Singular Butantã | | | | | | Pin Estação Vila Sônia | | | | |
|---|---|---|---|---|---|---|---|---|---|---|---|---|---|---|---|---|---|---|---|---|---|
| Tipologias | Avaliação | Preço Nominal | CEF | Renda | % Unidades | Preço Nominal | CEF | Renda | Dif | Farol | Avaliação | Preço Nominal | CEF | Renda | Dif | Farol | Preço Nominal | CEF | Renda | Dif | Farol |
| HMP - 1 Dorm | - | - | - | - | - | - | - | - | - | - | - | - | - | - | - | - | 275.777 | 220.622 | 5.300 | - | - |
| HMP | 293.000 | 257.682 | 201.273 | 4.500 | 41% | 324.000 | 259.200 | 6.300 | 1.800 | ● | 328.000 | 257.320 | 205.856 | 4.600 | 100 | ● | - | - | - | - | - |
| HMP - Varanda | 309.000 | 281.214 | 219.633 | 5.300 | 39% | - | - | - | - | - | 354.000 | 292.639 | 234.111 | 5.700 | 400 | ● | - | - | - | - | - |
| R2V - Varanda | 309.000 | 288.596 | 226.099 | 5.500 | 20% | 459.000 | 367.200 | 8.600 | 3.100 | ● | 354.000 | 307.775 | 246.220 | 6.000 | 500 | ● | 317.009 | 253.607 | 6.200 | 700 | ● |
| R2V - Varanda + Vaga | - | - | - | - | - | - | - | - | - | - | 395.000 | 353.185 | 282.548 | 6.900 | - | - | - | - | - | - | - |

## Parecer Ciclo

O Ciclo validou tanto o preço quanto o VSO como viáveis. A região do Pirajussara é muito positiva, próxima ao lançamento Max Vila Sônia. Os concorrentes existentes possuem preços mais altos e políticas de créditos mais restritivas, exigindo rendas superiores.

Pareceres

Análise da Mancha e Implantação

Prospecção

Operações

Incorporação

Inteligência de Mercado

Financeiro

Anexos

# Informações Financeiras

## Pirajussara - SP - São Paulo Capital

### Datas e Prazos

| | Compra | Lançamento | Início Obra | Término Obra | LÇTO até IO | IO até TO | Chaves | LÇTO até Chaves |
|---|---|---|---|---|---|---|---|---|
| **Consolidado** | dez-25 | | | | | | | |
| **F1 - HIS 2 - sem varanda** | | dez-28 | jun-29 | abr-31 | 6 meses | 22 meses | dez-31 | 36 meses |
| **F1 - HIS 2 - com varanda** | | dez-28 | jun-29 | abr-31 | 6 meses | 22 meses | dez-31 | 36 meses |
| **F1 - R2V - com varanda** | | dez-28 | jun-29 | abr-31 | 6 meses | 22 meses | dez-31 | 36 meses |
| **F2 - HIS 2 - sem varanda** | | jun-30 | dez-30 | jul-32 | 6 meses | 19 meses | jun-33 | 36 meses |
| **F2 - HIS 2 - com varanda** | | jun-30 | dez-30 | jul-32 | 6 meses | 19 meses | jun-33 | 36 meses |
| **F2 - R2V - com varanda** | | jun-30 | dez-30 | jul-32 | 6 meses | 19 meses | jun-33 | 36 meses |
| **F2- HIS 2 - 1D** | | jun-30 | dez-30 | jul-32 | 6 meses | 19 meses | jun-33 | 36 meses |

### Terreno e Incorridos

| | | | | | | | |
|---|---|---|---|---|---|---|---|
| **TOTAL (R$ + Perm.):** | 51,90 MM | **Incorrido Terreno:** | 0,00 MM | **Área do Terreno (100%):** | 11.599 m² | **Área Líquida do Terreno:** | 11.599 m² |
| **Cash:** | 0,00 MM | **Nº de Parcelas Cash :** | 0 | **Custo de terreno m²:** | 4.474,2 | **Custo de terreno m² Área Líquida:** | 4.474,2 |
| **Permuta Financeira:** | 51,90 MM (17,00%) | | | **VaR 25 (R$ mil):** | 0 | **Fração Terreno/Terreno + Custo Obra (%VGV):** | 17,0% / 53,4% |
| **Permuta Física:** | 0,00 MM (0,00%) | | | **VaR 26 (R$ mil):** | 0 | **CA Máx/Proj.** | 5,4 / 3,0 |
| **Ato / %VGV:** | 0,00 MM / 0,0% | | | **Incorrido de Construção:** | 0,00 MM | **Incorridos de Incorporação:** | 0,00 MM |

### Vendas

| Fases | Nº Pavimentos | Preço Raso Unit. | Qtde | Preço Unit. | Aval. CEF | Cond. Parcela | % Pró-soluto | % TCD |
|---|---|---|---|---|---|---|---|---|
| **F1 - HIS 2 - sem varanda** | T+9 | 243.898 | 297 | 257.682 | 293.000 | 96,6% | 76,2% | 27,1% |
| **F1 - HIS 2 - com varanda** | T+9 | 264.762 | 287 | 281.214 | 309.000 | 95,8% | 72,2% | 29,2% |
| **F1 - R2V - com varanda** | T+9 | 271.352 | 145 | 288.596 | 309.000 | 96,2% | 71,1% | 29,7% |
| **F2 - HIS 2 - sem varanda** | T+9 | 262.425 | 246 | 277.516 | 293.000 | 97,5% | 83,4% | 29,6% |
| **F2 - HIS 2 - com varanda** | T+9 | 285.043 | 34 | 303.054 | 309.000 | 97,0% | 79,0% | 32,0% |
| **F2 - R2V - com varanda** | T+9 | 292.183 | 74 | 311.062 | 309.000 | 97,4% | 77,8% | 32,5% |
| **F2- HIS 2 - 1D** | T+9 | 207.552 | 20 | 229.876 | 230.000 | 93,3% | 92,6% | 75,9% |

| | | | | | | | |
|---|---|---|---|---|---|---|---|
| **Unidades Totais:** | 1.103 | **Preço Médio:** | 276.768 | **Renda Média:** | 5.311 | **ITBI+Emol. Unit. Médio:** | 8.209 |
| **Unidades Tenda:** | 1.103 | **Avaliação Média:** | 299.691 | **Ato:** | 5.181 (0,98 Salários) | **Custo do Ciclo Unit.:** | 17.441 |
| **VSO:** | 31 Unidades | **VGV Total:** | 305.275.078 | **FGTS:** | 5.068 (0,95 Salários) | **Preço Raso Médio:** | 260.917 |
| **RET Médio:** | 4,0% | **VGV Tenda:** | 305.275.078 | **% em RET 1%:** | 1% | **Adc. Tx. de Aceleração Médio:** | 750 |

### Construção

| | | | | | | | |
|---|---|---|---|---|---|---|---|
| **Custo Total Unit. \| Corrigido:** | 100.851 \| 101.319 | **Eventuais:** | 4,00% | **Área priv (m²):** | 32,00 | **Gape / Mês Unit.:** | 11,08 |

### Resultado

| | | | | | | | |
|---|---|---|---|---|---|---|---|
| **LI (R$):** | **28.588.854** | **LI:** | **19,96%** | **Exposição de Caixa (R$):** | **13.543.547** | **Margem Bruta Econômica:** | **37,78%** |
| **TIR:** | **189,59%** | **LI Aprovação:** | **20,00%** | **Ger. Caixa 12 meses (R$):** | **0** | **Margem Bruta REF:** | **41,90%** |
| **Exposição de Caixa:** | **3,82%** | **Δ LI:** | **-0,04%** | **Ger. Caixa 24 meses (R$):** | **0** | **Margem Rasa Econômica:** | **33,49%** |
| **Payback Contingente (21 m):** | **18 m/ (-3 m)** | **LI Resiliência:** | **13,22%** | **Ger. Caixa Marginal (R$):** | **80.915.230** | **Margem Rasa REF:** | **38,38%** |
| **Payback Consolidado:** | **18 meses** | | | | | **Margem de Contribuição Econômica:** | **25,14%** |

# Informações Financeiras

| R$ Mil - Valores Nominais - Compra | Pirajussara | | F1 - HIS 2 - sem varanda | | F1 - HIS 2 - com varanda | | F1 - R2V - com varanda | | F2 - HIS 2 - sem varanda | | F2 - HIS 2 - com varanda | | F2 - R2V - com varanda | | F2- HIS 2 - 1D | |
|---|---|---|---|---|---|---|---|---|---|---|---|---|---|---|---|---|
| | Nominal | % | Nominal | % | Nominal | % | Nominal | % | Nominal | % | Nominal | % | Nominal | % | Nominal | % |
| Receita | 354.842 | 100,0% | 86.636 | 100,0% | 91.499 | 100,0% | 47.453 | 100,0% | 83.006 | 100,0% | 12.570 | 100,0% | 28.020 | 100,0% | 5.657 | 100,0% |
| PIS/COFINS | (7.737) | 2,2% | (1.900) | 2,2% | (2.007) | 2,2% | (1.041) | 2,2% | (1.821) | 2,2% | (276) | 2,2% | (615) | 2,2% | (78) | 1,4% |
| Custo Total | (215.985) | 62,2% | (54.958) | 64,9% | (54.295) | 60,7% | (27.591) | 59,4% | (51.796) | 63,8% | (7.327) | 59,6% | (16.020) | 58,5% | (4.000) | 71,7% |
| Custo Terreno | (57.471) | 16,6% | (14.102) | 16,6% | (14.833) | 16,6% | (7.690) | 16,6% | (13.438) | 16,6% | (2.024) | 16,5% | (4.507) | 16,4% | (876) | 15,7% |
| Custo Relacionados a Terreno | (2.251) | 0,6% | (579) | 0,7% | (582) | 0,7% | (298) | 0,6% | (516) | 0,6% | (74) | 0,6% | (164) | 0,6% | (39) | 0,7% |
| Custos de Incorporação | (7.486) | 2,2% | (1.955) | 2,3% | (1.848) | 2,1% | (893) | 1,9% | (1.853) | 2,3% | (254) | 2,1% | (524) | 1,9% | (159) | 2,9% |
| Custo de Construção | (148.777) | 42,9% | (38.322) | 45,2% | (37.031) | 41,4% | (18.709) | 40,3% | (35.988) | 44,3% | (4.974) | 40,5% | (10.826) | 39,5% | (2.926) | 52,4% |
| Lucro Bruto Econômico | 131.120 | 37,8% | 29.778 | 35,1% | 35.197 | 39,3% | 18.822 | 40,6% | 29.390 | 36,2% | 4.967 | 40,4% | 11.385 | 41,5% | 1.580 | 28,3% |
| Custo para Rateio | - | 0,0% | - | 0,0% | - | 0,0% | - | 0,0% | - | 0,0% | - | 0,0% | - | 0,0% | - | 0,0% |
| Lucro Bruto Contábil | 131.120 | 37,8% | 29.778 | 35,1% | 35.197 | 39,3% | 18.822 | 40,6% | 29.390 | 36,2% | 4.967 | 40,4% | 11.385 | 41,5% | 1.580 | 28,3% |
| Despesas de Selling | (35.713) | 10,3% | (8.726) | 10,3% | (9.253) | 10,3% | (4.794) | 10,3% | (8.377) | 10,3% | (1.268) | 10,3% | (2.834) | 10,3% | (461) | 8,3% |
| Contingência | (8.161) | 2,4% | (1.993) | 2,4% | (2.104) | 2,4% | (1.091) | 2,4% | (1.909) | 2,4% | (289) | 2,4% | (644) | 2,4% | (130) | 2,3% |
| Margem de Contribuição | 87.245 | 25,1% | 19.059 | 22,5% | 23.840 | 26,6% | 12.936 | 27,9% | 19.104 | 23,5% | 3.410 | 27,7% | 7.907 | 28,9% | 989 | 17,7% |
| IR e CSLL | (6.330) | 1,8% | (1.555) | 1,8% | (1.642) | 1,8% | (852) | 1,8% | (1.490) | 1,8% | (226) | 1,8% | (503) | 1,8% | (63) | 1,1% |
| Margem Líquida | 80.915 | 23,3% | 17.505 | 20,7% | 22.198 | 24,8% | 12.084 | 26,0% | 17.614 | 21,7% | 3.185 | 25,9% | 7.404 | 27,0% | 925 | 16,6% |
| Lucro Bruto REF Unit. | 140.359 | 41,9% | 120.027 | 39,5% | 143.625 | 43,3% | 150.950 | 44,3% | 142.788 | 40,6% | 170.033 | 44,3% | 179.405 | 45,4% | 93.874 | 32,2% |
| Lucro Raso REF Unit. | 121.217 | 38,4% | 103.823 | 36,1% | 124.271 | 39,8% | 130.658 | 40,8% | 123.703 | 37,2% | 147.261 | 40,8% | 155.493 | 41,9% | 65.580 | 24,9% |

| R$ Mil - VPL - Compra | Pirajussara | | F1 - HIS 2 - sem varanda | | F1 - HIS 2 - com varanda | | F1 - R2V - com varanda | | F2 - HIS 2 - sem varanda | | F2 - HIS 2 - com varanda | | F2 - R2V - com varanda | | F2- HIS 2 - 1D | |
|---|---|---|---|---|---|---|---|---|---|---|---|---|---|---|---|---|
| | VP | % | VP | % | VP | % | VP | % | VP | % | VP | % | VP | % | VP | % |
| Receitas | 143.230 | 100,0% | 38.123 | 100,0% | 40.109 | 100,0% | 20.735 | 100,0% | 28.586 | 100,0% | 4.279 | 100,0% | 9.532 | 100,0% | 1.867 | 100,0% |
| PIS/COFINS | (3.080) | 2,2% | (824) | 2,2% | (867) | 2,2% | (448) | 2,2% | (618) | 2,2% | (92) | 2,2% | (206) | 2,2% | (25) | 1,4% |
| Custos e Despesas Totais | (111.561) | 77,9% | (30.549) | 80,1% | (30.527) | 76,1% | (15.551) | 75,0% | (22.850) | 79,9% | (3.265) | 76,3% | (7.153) | 75,0% | (1.667) | 89,3% |
| Custo Terreno | (22.729) | 15,9% | (6.056) | 15,9% | (6.359) | 15,9% | (3.289) | 15,9% | (4.546) | 15,9% | (679) | 15,9% | (1.511) | 15,8% | (290) | 15,5% |
| Custo Relacionados a Terreno | (1.294) | 0,9% | (332) | 0,9% | (335) | 0,8% | (171) | 0,8% | (296) | 1,0% | (43) | 1,0% | (94) | 1,0% | (22) | 1,2% |
| Custos de Incorporação | (3.665) | 2,6% | (1.000) | 2,6% | (946) | 2,4% | (457) | 2,2% | (836) | 2,9% | (115) | 2,7% | (238) | 2,5% | (73) | 3,9% |
| Custo de Construção | (62.840) | 43,9% | (17.547) | 46,0% | (16.957) | 42,3% | (8.567) | 41,3% | (13.003) | 45,5% | (1.797) | 42,0% | (3.911) | 41,0% | (1.057) | 56,6% |
| Despesas de Selling | (16.830) | 11,8% | (4.497) | 11,8% | (4.753) | 11,9% | (2.458) | 11,9% | (3.322) | 11,6% | (504) | 11,8% | (1.115) | 11,7% | (181) | 9,7% |
| Contingência | (1.684) | 1,2% | (443) | 1,2% | (468) | 1,2% | (243) | 1,2% | (341) | 1,2% | (52) | 1,2% | (115) | 1,2% | (23) | 1,2% |
| IR e CSLL | (2.520) | 1,8% | (674) | 1,8% | (709) | 1,8% | (367) | 1,8% | (505) | 1,8% | (76) | 1,8% | (169) | 1,8% | (21) | 1,1% |
| Lucro Imobiliário | 28.589 | 20,0% | 6.751 | 17,7% | 8.715 | 21,7% | 4.736 | 22,8% | 5.118 | 17,9% | 922 | 21,5% | 2.173 | 22,8% | 175 | 9,4% |

Pareceres

Análise da Mancha e Implantação

Prospecção

Operações

Incorporação

Inteligência de Mercado

Financeiro

Anexos

- **DESCRIÇÃO DO IMÓVEL:** localizado na **Avenida Pirajussara, 4359, Ferreira/SP, CEP: 05534-000**, objeto da **Matrícula 215.538 do 18º Oficial de Registro de Imóveis de São Paulo/SP** e cadastrado no contribuinte municipal nº 123.001.0007-9.

- **PROPRIETÁRIA: Partifib Projetos Imobiliários Pirajussara Ltda.** (Grafia anterior: Partifib Projetos Imobiliários F71 Ltda.):

  - **Título Aquisitivo**: por meio de Escritura de Venda e Compra, lavrada em 08/09/2021, perante o 15º Tabelião de Notas de São Paulo/SP, às fls. 347 do Livro nº 3.215, registrada sob o R.03, em 27/09/2021, na referida matrícula nº 215.538.

- **CONSIDERAÇÕES JURÍDICAS SOBRE O IMÓVEL:**

  - **(a) Retificação:** Será analisado em estudo técnico, não obstante, destacamos que consta matrícula do **Imóvel** encerramento da área de 11.598,32m² e na certidão de dados cadastrais da Prefeitura Municipal de São Paulo a área total de 11.599,00m², portanto, uma diferença mínima de 0,68m², não trazendo, a princípio, risco de retificação de área; **(b) Loteamento:** Durante a *Due Diligence* será investigado se o **Imóvel** possui origem de loteamento e em caso positivo verificaremos eventuais restrições; **(c) Desmembramento:** Até o momento não foi informado se será necessário o desmembramento das áreas em referência para consecução do Empreendimento Imobiliário; **(d) Área construída:** consta na matrícula do **Imóvel** a menção de "Um Terreno" e na certidão de dados cadastrais da Prefeitura Municipal de São Paulo a construção de 6.438,00m², não sendo possível verificar se encontra-se regular, o que será apurado durante a *Due Diligence*; **(f) Multas:** Durante a *Due Diligence* buscaremos informações se há multas que recaem sobre o **Imóvel**; **(g) Ônus e Gravames**: consta registrado na matrícula do **Imóvel**, no R.05 de 18/11/2024 a alienação fiduciária à True Securitizadora S/A, para garantia de 31% do valor total de R$ 100.000.000,00, contendo como devedora a Fibra Participações S/A; **(h) Débitos de IPTU**: Em *Due Diligence* iremos validar os débitos, não obstante, conforme consulta realizada em 28/10/2025, a certidão referente aos Débitos de Tributos Imobiliários, encontra-se regular, no entanto, constam dois PPIs no Demonstrativo Unificado do Contribuinte (DUC) da Secretaria Municipal da Fazenda, sob nº **(i)** 2.774.330-6, relativo aos exercícios de 2010 a 2014, sendo necessária apresentação de extrato para conferência do valor atualizado e **(ii)** 2.791.901-3, relativo ao exercício de 2015, em dívida ativa e no valor atualizado de R$ 270.860,41; **(i) Ocupação**: nos termos da cláusula 4.5 da minuta do Contrato, consta a indicação de locação no **Imóvel**. De acordo com o apurado em DD Prévia, constam dois contratos de locação não residenciais da Antecessora Percsa Imóveis e Participações Ltda. com a Sociedade Educacional Ítaca S.A., melhor descritos nos apontamentos da Proprietária Tabular; **(j) CONDEPHAAT, CONPRESP, IPHAN:** Em *Due Diligence* iremos analisar os documentos que informem se há apontamentos e **(k) Desapropriação e Melhoramentos:** Em *Due Diligence* iremos analisar os documentos que informem se há apontamentos.

- **CONSIDERAÇÕES PRELIMINARES SOBRE A PROPRIETÁRIA:**

- Constatou-se 04 apontamentos cíveis de 1ª Instância, relativos a Locação não residencial com a Sociedade Educacional Ítaca S.A., sendo eles:

**(i) Ação de Consignatória de Aluguéis nº 1109520-34.2021.8.26.0100, em tramite perante a 2ª Vara Cível do Foro Regional do Butantã. Distribuído em 15/10/2021, pela Sociedade Educacional Ítaca S/A. Valor da ação: R$ 908.256,84:** A Autora alega ter celebrado contrato de locação não residencial com Ré Percsa, em 01/01/2003, relativo ao imóvel objeto da matrícula 215.538, do 18º Registro de Imóveis de São Paulo, especificamente para a instalação de estabelecimento de ensino, sendo ao longo dos anos firmado o aditivo 01 (01/01/2008); aditivo 02 (01/012013) e aditivo 03 (01/01/2018), este último com vigência até 31/12/2022. Além de um segundo contrato de locação, firmado em 25/04/2013, referente à área adicional e contígua para construção de quadra esportiva, com aditivo, com vigência até 31/05/2023. Sustenta que em 2021 tomou conhecimento de venda do imóvel à Fibra Experts, exercendo seu direito de preferência na aquisição, através do envio de notificação, sendo, contudo, surpreendida com outra notificação extrajudicial com a comunicação da venda e denúncia vazia do contrato de locação, para desocupação em 90 dias. Deste modo, diante da incerteza quanto ao destinatário e valor do pagamento, ajuizou a consignatória para depósito judicial dos aluguéis e encargos. **Sentença: julgada procedente em 24/04/2023;**

**(ii) Tutela Cautelar Antecedente nº 1007182-13.2021.8.26.0704, em tramite perante a 2ª Vara Cível do Foro Regional do Butantã. Distribuído em 02/03/2022. Pela Sociedade Educacional Ítaca S/A. Valor da ação: R$ 50.000.000,00:** A Autora distribuiu a tutela cautelar por dependência da Ação de Consignatória de Aluguéis, alegando, em suma, os mesmos termos dos autos nº 1109520-34.2021.8.26.0100, pleiteando pela declaração de nulidade do negócio, e, a averbação da ação na matrícula do imóvel. Sentença: julgada improcedente em 24/04/2023;

**(iii) Ação Renovatória de Locação nº 1000371-03.2022.8.26.0704, em tramite perante a 2ª Vara Cível do Foro Regional do Butantã. Distribuído em 26/01/2022, pela Sociedade Educacional Itaca Ltda-EPP. Valor da ação: R$ 908.256,84:** A Autora distribuiu a Renovatória por dependência da Ação de Consignatória de Aluguéis, alegando, em suma, os mesmos termos dos autos nº 1109520-34.2021.8.26.0100, e, por alegar que preenchia os requisitos para a ação de renovação de aluguéis; que sempre cumpriu com os pagamentos do aluguel e encargos de forma pontual; propôs manter os estritos termos da relação locatícia da área maior, no valor da renovação de R$ 54.126,25, a ser devidamente atualizado no formato contratual, para correção no período de janeiro/2022, para janeiro/2023; para novo período de 05 anos, com vigência de 01/01/2023 a 31/12/2027**. Sentença: julgada improcedente em 24/04/2023**;

## ➢ CONSIDERAÇÕES PRELIMINARES SOBRE A PROPRIETÁRIA:

**(iv) Ação Renovatória de Locação nº 1006185-93.2022.8.26.0704, em tramite perante a 2ª Vara Cível do Foro Regional do Butantã. Distribuído em 18/08/2022, pela Sociedade Educacional Ítaca S.a. Valor da ação: R$ 107.745,84:** A Autora distribuiu a Renovatória por dependência da Renovatória nº 1000371-03.2022.8.26.0704, alegando, em suma, os mesmos termos dos autos da consignação, e, por alegar que preenche os requisitos para a ação de renovação de aluguéis; que sempre cumpriu com os pagamentos do aluguel e encargos de forma pontual; propôs manter os estritos termos da relação locatícia da área menor (quadra esportiva), no valor da renovação de R$ 8.978,82, com a data base de junho de 2022, para novo período de 05 anos contratuais, com a vigência de 01/06/2023 à 01/06/2028. **Sentença: julgada improcedente em 24/04/2023**.

Adicionalmente, aos apontamentos acima, a **Partifib Projetos Imobiliários F71 Ltda., em 10/02/2022, distribuiu a Ação de Despejo nº 1000777-24.2022.8.26.0704**, alegando que os contratos de locação não residencial firmados (da área maior e da área menor), possuíam vigência até 31/12/2022 e 31/05/2023, respectivamente, e, considerando a aquisição, conforme registro R.03 de 27/09/2021 e inexistência de averbação dos contratos de locação na matrícula, notificou a Ré acerca do desinteresse na manutenção da relação locatícia, mediante denúncia do contrato e concessão do prazo de 90 dias para desocupação. E, não ocorrendo a desocupação do imóvel, ingressou com a ação para realização de futura incorporação imobiliária e edificação de empreendimento. Sendo o **pedido julgado procedente em sentença de 24/04/2023**.

Não obstante, em que pese a dependência na Ação de Consignatória de Aluguéis, e, portanto, sentença conexa aquela ação, as partes recorreram nesta Ação de Despejo, sendo alcançada além da condenação dos honorários advocatícios, a revista no seguinte sentido:

**(i) mantendo-se:**

**(a)** a improcedência do pedido de declaração de nulidade de negócio jurídico cumulado com pedidos indenizatórios; **(b)** a improcedência dos pedidos renovatórios em relação à ré Percsa; **(c)** a procedência do pedido de consignação em pagamento, apenas invertida a imposição sucumbencial;

**(ii) revendo-se:**

**(a)** improcedência do pedido de despejo (Processo 1000777-24.2022.8.26.0704); e **(b)** procedência dos pedidos renovatórios de locação em relação à ré Partifib (Processos 1000371-03.20228.26.0704 e 1006185-93.2022.8.26.0704), sendo determinado que diante da divergência entre as partes em relação ao valor locativo real dos imóveis, entende-se pertinente a realização de perícia técnica, a fim de definir com precisão o valor de mercado da locação e, assim, a quantia a ser paga pela Ítaca em favor da Partifib, o que deverá ser realizado em liquidação de sentença.

- **CONSIDERAÇÕES PRELIMINARES SOBRE A PROPRIETÁRIA:**

- E, nos apontamentos cíveis de 2ª Instância, destaca-se a **Apelação Cível nº 1007813-83.2023.8.26.0704, em tramite perante a 1ª Câmara de Direito Privado:** relativo a Ação Cominatória, julgada procedentes para condenar a requerida a tolerar que a requerente ingresse em seu imóvel para realização de vistoria (i) em dias e horários previamente combinados e nos quais não estejam sendo conduzidas atividades escolares, inclusive as férias de julho vindouras, (ii) sempre mediante profissionais qualificados e desde que previamente informados à requerida, que acompanhará a diligência mediante representante designado e (iii) que deve se findar uma vez esgotada a finalidade declarada e não danificar qualquer propriedade da requerida, arcando a requerida com as custas e despesas processuais e honorários advocatícios de 10% do valor da causa. As partes aguardam o julgamento do recurso de Apelação interposto pela Ítaca, com efeito suspensivo.

- **CONCLUSÃO:**

  - A análise preliminar concluiu que: **(i)** sobre a **Área construída** consta na matrícula do **Imóvel** a menção de "Um Terreno" e na certidão de dados cadastrais da Prefeitura Municipal de São Paulo a construção de 6.438,00m², não sendo possível verificar se encontra-se regular, podendo o Oficial de Registro de Imóveis, eventualmente, exigir a regularização da edificação e a averbação da área total construída na matrícula do Imóvel, por ocasião da averbação da futura demolição necessária à implantação do Empreendimento; **(ii)** a **alienação fiduciária** do imóvel à True Securitizadora S/A, para garantia de 31% do valor total de R$ 100.000.000,00, contendo como devedora a Fibra Participações S/A, conforme R.05 de 18/11/2024, devendo ocorrer a devida regularização e apresentação da matrícula livre de ônus e gravames, nos termos das condições resolutivas do Compromisso de Compra e Venda; **(iii)** os **Débitos de IPTU** inscritos no PPI sob nº *(i)* 2.774.330-6, relativo aos exercícios de 2010 a 2014, sendo necessária apresentação de extrato para conferência do valor atualizado e *(ii)* 2.791.901-3, relativo ao exercício de 2015, em dívida ativa e no valor atualizado de R$ 270.860,41, devendo ocorrer o pagamento dos débitos previamente a outorga da escritura de venda e compra; e **(iv) Ocupação**: com a procedência alcançada em 2ª instância, nos pedidos renovatórios, o contrato de locação da área maior possuirá vigência até 31/12/2027 e da área menor (quadra esportiva) possuirá vigência até 01/06/2028, sendo determinado a realização de perícia técnica em liquidação de sentença, devendo ocorrer a devida Notificação do Inquilino sobre a venda do Imóvel com a obtenção da renúncia do direito de preferência e Distrato da Locação contendo a ratificação da renúncia ao direito de preferência na aquisição, nos termos das condições resolutivas do Compromisso de Compra e Venda firmado com a Proprietária Tabular. A visita ao imóvel está temporariamente impedida pelo efeito suspensivo da ação cominatória.

# LEGALIZAÇÃO E DPP

➢ **ÁREA DE IMPLANTAÇÃO**

- O terreno é composto por 1 matrícula (215.538 – 18º ORI), em nome de pessoa jurídica, que totaliza uma área escriturária de 11.598,32m²;
- O cadastro do imóvel é urbano;
- O cenário foi desenvolvido sobre a poligonal do planialtimétrico enviado pelo proprietário, definida em 11.598,32m²;
- BDT emitida com sinalização de faixa de APP que coincide com a faixa do melhoramento viário, respeitada em projeto,
- Rua Santa Eufrásia, conforme BDT possui largura de 7,8m. Já a Avenida Pirajussara possui 13,00m de largura.

➢ **DIRETRIZES URBANÍSTICAS**

- O terreno esta inserido em ZM, conforme decreto 63.728/2024:
  - C.A. máximo: **3,0 para EHIS, com** restrição de gabarito de 28,00m e TO 70%, PA 07 (20%), sendo necessário a reserva de calçada.
    - Com benefícios: CA 5,6 (+ 1,5 de HIS-1, + 0,90 de cota solidariedade, +0,20 de fachada ativa)
    - Utilizado em projeto: CA 3,14 (Benefício HIS-1 – 0,14)
- Terreno não será parcelado;
- Usos permitidos: Todos (EHIS, EHMP e R2V)
- O estudo considera implantação de 1 condomínio com 1.103 unidades. Destas, 50 unidades são de incentivo e 20 unidades com 1 dormitório. Estão divididas em:
  - 4 torres 12PP T+9 com 118 UHs
  - 3 torres 14PP T+9 com 138 Uhs
  - 1 torre 22PP T+9 com 217 Uhs
- Em função do zoneamento não é exigido cota a parte, cenário atende;
- A legislação não exige vaga de garagem, cenário considera 1 vaga PNE e 1 vaga de idoso;

➢ **GRAPROHAB**

- Número de UH do estudo (EM) supera o 800 UH (1.103UH), sendo necessário a aprovação;

## ➢ AVALIAÇÕES AMBIENTAIS

**Arbóreo**

- Conforme BDT, o terreno **não** é considerado como Patrimônio Ambiental
- Incide APP sobre o terreno, porém sem influência na implantação;
- Necessário laudo arbóreo para confirmação de existência de fragmento. Com análise do local, não aparenta ter;
- Não foi enviado o paramétrico de comitê para análise.
- A propriedade não está inserida em Área de Patrimônio Ambiental (APA) e Área de Proteção de Mananciais (APRM), próximo a uma Unidade de Conservação segundo geosampa;
- Cenário considera a supressão de todos os exemplares localizados no interior dos lotes;
- Compensação considerando: árvores nativas: 10:01; Exóticas: 01:01; tocos ou mortos: 01:01. Para cenário R2v seguir legislação;

**Hidrografia**

- O Imóvel apresenta corpos d'água próximo (Córrego Pirajuçara – canalizado e enterrado) a cerca de 20m;

## ➢ AVALIAÇÕES AMBIENTAIS

**Contaminação (Potencial Contaminado)**

1- Conforme consulta ao sigamgeo o terreno não é objeto de contaminação ou possui suspeita. Porém, lotes ao redor são considerados contaminados.
2 – BDT informa que o imóvel não é cadastrado como contaminado ou com suspeita de contaminação perante a municipalidade;

Para efeito de comitê essencial foi considerado o terreno como **potencial contaminado** devido ao seu entorno;

# LEGALIZAÇÃO E DPP

➢ **ÓRGÃOS DE PATRIMÔNIO HISTÓRICO**

- De acordo com a certidão CIT, o imóvel é isento de aprovação perante ao CONPRESP, CONDEPHAAT, UPPH e DPH;
- Necessária a obtenção de TRE do IPHAN.

➢ **URBANIZAÇÃO**

- Consta DUP para o terreno de acordo com camada do geosampa. Porém, BDT veio com a informação que não consta. Aguardando emissão de Certidão de Desapropriação;
- O imóvel é atingido por plano de melhoramento viário, já previsto em EM;
- Não consta área pública no imóvel, nem croqui patrimonial;

➢ **OUTROS ITENS NECESSÁRIOS/ESPECÍFICOS**

- Observado pendencia financeira na consulta preliminar no site da Prefeitura;
- Há edificação a ser demolida no terreno. Necessária regularização de matrícula;
- Já existem laudos emitidos para o terreno (área das quadras), porém não tivemos acesso;
- Possivelmente teremos análise de CEUSO por conta do nível de água. Camadas do geosampa indica históricos de inundação na temporalidade de 5, 25 e 100 anos.
- <u>Segundo análise Jurídica o acesso do terreno da escola só será possível, para início dos estudos ambientais e cadastramento arbóreo, a partir de dezembro de 2027. Desta forma, o prazo de aprovação começa a partir do acesso ao terreno.</u>

# Obrigado(a)