Tenda

sua próxima conquista

Book de Investimento - Comitê Ampliado

Regional: SP

Projeto: Francisco Velho

Data Comitê: 01/12/2025

One Page – Francisco Velho - Aprovação

Cidade	São Paulo	Mancha de demanda	SP - SZL1 - São Paulo Leste 1
Regional	SP	Cluster MPR	2 - Amarelo
Cenário de Aprovação	Aprovação	Tipo de Aprovação	Consolidado
Fase Anterior	N/A		
Tipo de Comitê	Investimento	Versão da VF	Versão 1.0: Nov

[1]

Unidades (Fases)	612 (1)	CA Máx | Proj	4,1 | 2,1
Unidades com Vaga (%)	0 (0%)	Escritura | Lançamento	set/27 | nov/27
Unidades com Varandas (%)	288 (47%)	Tipologia	F2E - Concreto

[2]

Valor Líquido do Terreno (% VGV)	9.700 (6,6%)	Un. Perm. Fís (% Ter)	0 (0,0%)
Cash (Correção)	9.700 (IPCA)	%VGV Perm Fin Líquida (% Ter)	0,0% (0,0%)
Valor R$/m²	1.118	VAR (%VGV)	000 (0,0%)

[3]

Custo Construção (%VGV)	64.049 (43,6%)	Indireto Unit.	19.399
Prazo da Obra (meses)	22	Torre Unit.	55.819
Custo Total Unit. (LPU):	104.655 (96)	Infra Unit.	13.399
Início de Obra	mai-28	Fundação Unit.	7.506

[4]

Preço Nominal Unit.	240.157	VSO	34
Preço Raso Unit.	222.560	Referência	Vision
Avaliação Unit.	266.765	Renda (% em RET 1%)	4.086 (0,0%)

[5]

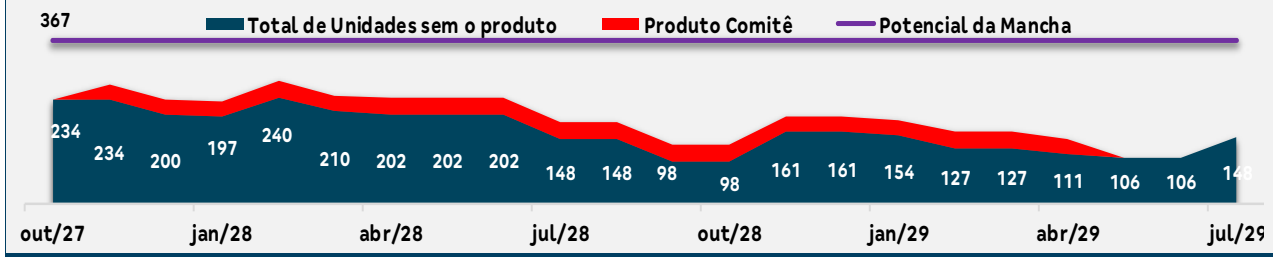

LI (Régua):	20,3% (20,0%)	Margem Bruta Econômica:	39,6%
LI Resiliência:	11,9% (N/A)	Margem Rasa Econômica:	34,3%
Margem Bruta REF:	42,9%	Margem Contribuição Econômica:	28,0%
Margem Rasa REF:	38,4%	Exposição (% VGV):	19.675 (12,3%)
TIR:	101,6%	VGV Total:	146.976
Payback Contingente (21 m) :	20 m/ (-1 m)	Ger. Caixa 12 meses (R$):	(600)
Payback Consolidado:	20	Ger. Caixa 24 meses (R$):	(3.289)

Destaques

[1] Projeto: Francisco Velho, localizado na Zona Leste, composto por 5 torres, zoneamento ZPI com limite de gabarito T+9, totalizando 612 Uhs em fase única; Contempla 47% de atributo varanda e zero vagas; projeto com atingimento de CA 2.1X (CA Máx 4.04) ;

[2] Condição Comercial:

- R$9.700.000 - 100% em Cash -> R$ 532/CA e R$ 1.118/m² (fração aprox. 6,6%)
- **Sinal:** R$500.000 (0,34% do VGV) pagos em até 30 dias da notificação de superação das Res. I do contrato.
- **Saldo:** R$ 9.200.000* pagos em 36 parcelas mensais de R$255.555,56 a partir da escritura. As parcelas serão reajustadas por IPCA a partir da superação das Res.II (escritura inclusive)

***Antecipação de saldo no valor de 100k pago semestralmente, sendo a primeira iniciando 6 meses do pagamento do "sinal". Os valores serão descontados das parcelas do saldo pós escritura (estimativa 200k – 0,14% do VGV). O pagamento deverá seguir semestralmente até que ocorra a superação das Res.II.**

OBS:

- Em caso de distrato antes da escritura, as proprietárias retém 300k e devolvem a diferença do que receberam.
- Terreno já esteve no *landbank* da TND com preço de 10MM a uma fração que representava 15% do VGV; terreno distratado em 2021;

[3] Custo de Construção: AP contempla EEE devido a localização do ponto de interligação na Avenida Jacu Pêssego, entretanto foi analisado com o time de Infra a possibilidade de alterar o ponto de ligação realizando uma intervenção transversal na avenida utilizando o método *Tunel Linner*. Se esta solução representar economia, esta alteração deverá ser pleiteada junto a SABESP.

[4] Precificação Vision:
O Parque do Carmo e o Alvorada Aricanduva já capturam rendas a partir de 4,1K em unidades sem atributos trazendo conforto a precificação *vision* do Francisco Velho em que as Uhs com atributo Varanda (47%) capturam renda de 4,4k a um VSO de 16.

[5] Objetivo: submeter o projeto em comitê ampliado, com a baixa de 100% das uh – foi viável em função dos estudos técnicos que já tínhamos.

Obs.: Contaminação: Por orientação do nosso consultor (Arq Geo), iniciaremos o monitoramento tanto em solo quanto em água nos poços já existentes para verificar se os índices apontados no relatório anterior permanecem os mesmos, além da elaboração do laudo fase II para atualização dos parâmetros da nova DD. Caso os índices se mantenham, não haverá necessidade de realização de nenhuma intervenção tanto em solo quanto em água. Entretanto consideramos em VF uma verba de 400k conforme mencionado em contrato.
Arbóreo: No AP mantivemos parte das árvores no local onde havia maior adensamento, além da verba de compensação estimada por LEG.

- Pareceres
- Análise da Mancha e Implantação
- Prospecção
- Operações
- Inteligência de Mercado
- Financeiro

Farol Pareceres – Francisco Velho

Área	Riscos Associados	Parecer	Criticidade
Jurídico	A aquisição envolve dois imóveis e, conforme a due diligence, nada foi identificado que desabone as PROPRIETÁRIAS, bem como, inexistem débitos que onerem os IMÓVEIS. A titularidade dos IMÓVEIS está pendente de regularização, será regularizada pela transmissão direta para a COMPRADORA, via alvará judicial, já expedido, que deverá ser atualizado quando necessário. As PROPRIETÁRIAS declaram ter 3 inquilinos, com contrato de locação e comodato, e se responsabilizam pelos tramites de desocupação. Ingressaram com uma ação de despejo, em fase incial. As VENDEDORAS tomaram ciências sobre a existência de 02 (duas) Ações de Usucapião distribuídas em face de "desconhecidos", pelos seus locatários, sobre seus imóveis, em fase inicial, Processo nº 1079450-92.2025.8.26.0100 e Processo nº 1090646-59.2025.8.26.0100, dos quais ainda não são parte. Os processos de usucapião apresentam risco para operação, no entanto, considerando os contratos de locação apresentados pelas VENDEDORAS, entendemos que há possibilidade das ações serem extintas, o que será previsto contratualmente em cláusula resolutiva. A princípio, matrículas sem gravame, sem ônus e sem débitos, e a ação de usucapião poderá ser mitigada no decorrer do prazo contratual.	Ok com ressalvas	
Legalização	Estudos ambientais e cadastramento arbóreo elaborados em 2020, sem atualização para o cenário atual do terreno	Ok	
Produto	Factivel	ok	
GETEC	Após consulta com a Empresa ArqueGEO - Consultoria Socioambiental, com base na analise dos laudos de 2020, não teremos necessidade de colchão de brita e bota fora especial. É necessário a emissão de novos laudos para a analise conclusiva, após a emissão caso, o laudo seja alterado este custo deverá ser revisado.	Ok com ressalvas	
Logística	Sem riscos	Ok	
Inteligência de mercado	IM avalia o Preço vision como factível.	Ok	
Comercial/Ciclo	O Ciclo validou o preço e o VSO como viáveis.	Ok	
Estudos Econômicos	Ok, sem riscos associados.	Ok	

Pareceres

Análise da Mancha e Implantação

Prospecção

Operações

Inteligência de Mercado

Financeiro

Mancha de Demanda

MANCHAS DE DEMANDA

• SZL – São Paulo Leste

Lançamento

1. Tucumã
2. Oásis Penha
3. Viva Parque do Carmo
4. Reserva das Andorinhas
5. Palermo
6. Alvorada Aricanduva

LandBank

7. Florença
8. Lar de Itaquera | Sol de Itaquera
9. Viva Azul
10. Solar da Araucária
11. Jerivás
12. Amarilis
13. Marechal Tito
14. Francisco Velho

Cluster MPR – (Comitê)

Cluster 2 - Amarelo

Região

Capital

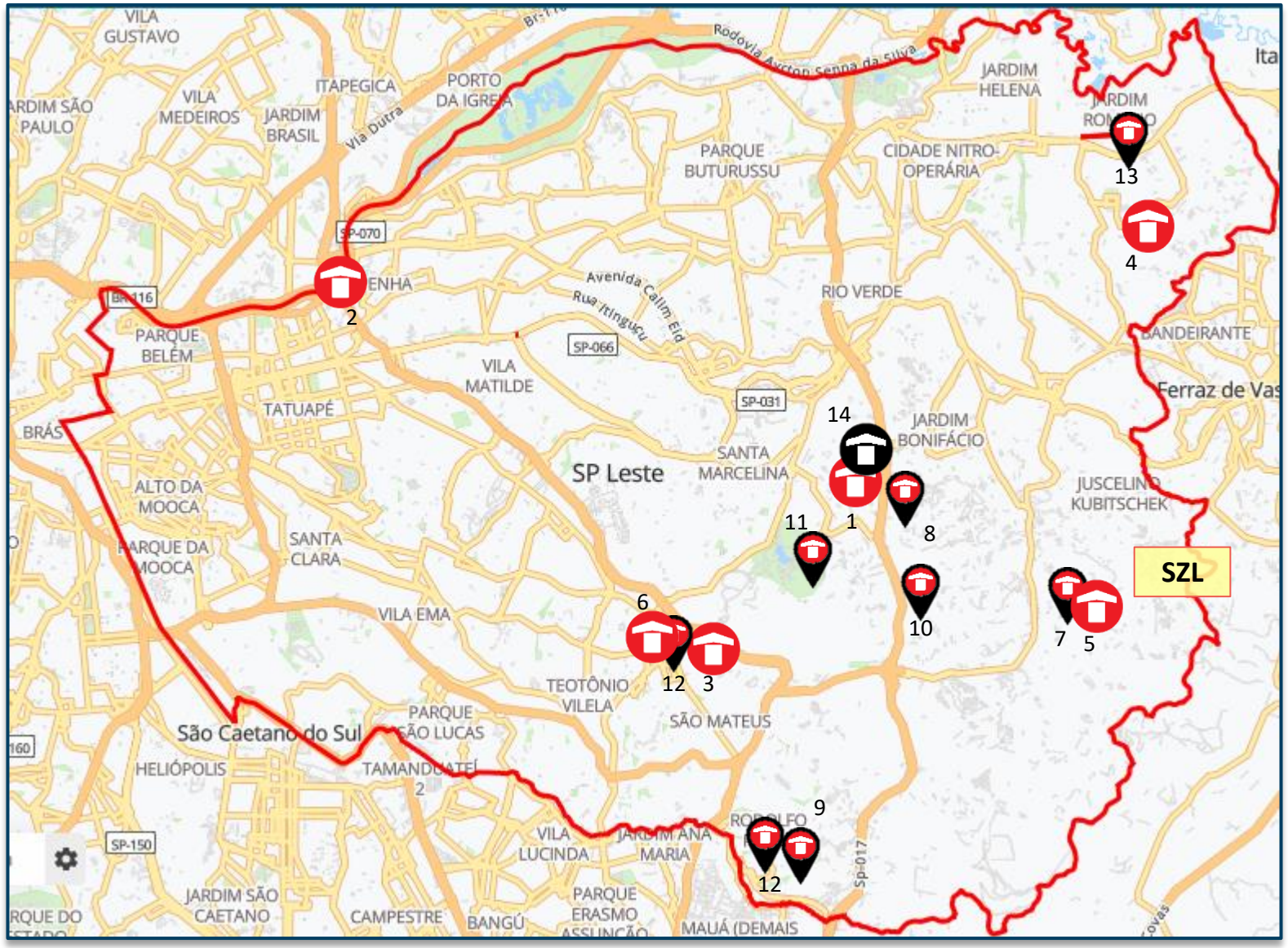

Lançados *LandBank* *Comitê*

Macrolocalização

PRODUTO

Empreendimento Francisco Velho | Investimento

Informações Gerais – Condomínio único			
Terreno	**Área terreno**	9.662,00m²	
	Menor poligonal	9.637,26m²	
	App/fna	Não	
	Reserva de calçada/ melhoramento víario	419,33m² /525,37m²	
	Fragmento Árboreo	628,03m²	
	Área liquida	8.675,98m²	
Diretrizes Urbanísticas	**Zoneamento**	ZPI-1	
	Ca máximo	4,04	ZONA: 2,25 INCENTIVO: 1,79
	Ca liquido	2,10	
	Ca projetado	2,10	
	Gabarito máximo	28 m / T+9	
Geral	**Total uh**	612	
	Total de vagas exigido	0 (0%)	
	Total de vagas projetado	1 PCD/CD	
Tipologia	**Tipologia**	Modular com elevador	
	Gabarito	T+09	
	Lâmina	08PP | 12PP | 18PP	
	Área privativa	31,20m², 31,43m², 32,95m² e 33,18m²	
	Varanda	Sim	
Condomínio	**Unidade pcd**	19	
	Unidade lazer|técnica	3 Unidades de Lazer + 5 CM/Lazer	
	Torre	5	
	Fase	Fase única	
Lazer	**Lazer Interno**	Espaço Office, Fitness, Salão de Festas Gourmet, Brinquedoteca	
	Lazer Externo	Salçaio de festas com Churrasqueira, Quadra Streetbal, Playkids, Play baby, Play Pet, Churrasqueira gourmet	

IMPLANTAÇÃO

LEGENDA:

01 Área técnica
02 Lazer
03 Reserva de Calçada/ Melhoramento Viário

Empreendimento Francisco Velho | Investimento

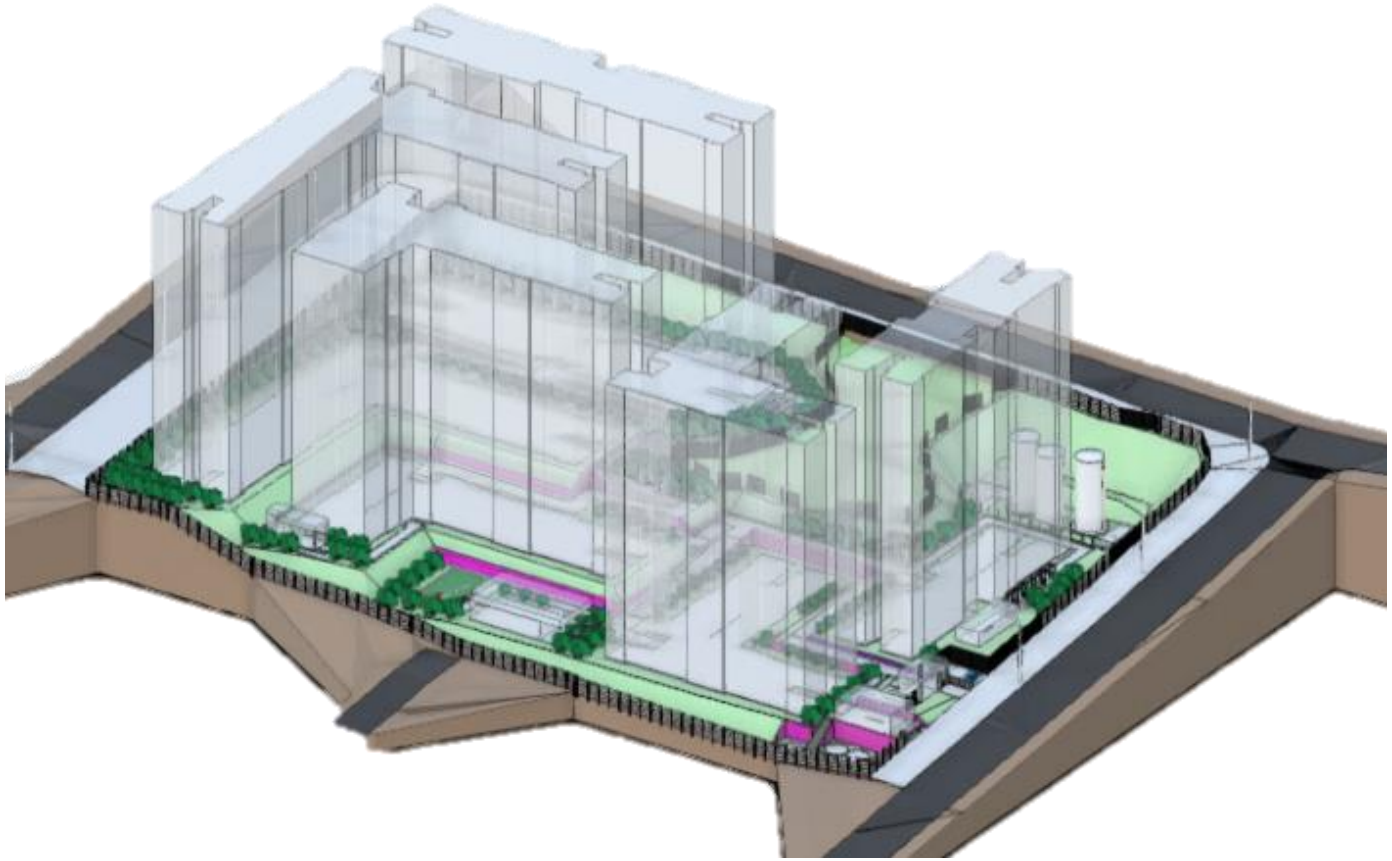

	Descrição	Criticidade	Observação
Usabilidade	**Acesso Empreendimento**	🟢	
	Percurso do pedestre até torre	🟢	
	Posição das torres	🟢	*Apesar das três vias que circundam o terreno possuírem reserva de calçada, o que dispensa a exigência de afastamento frontal, não foi possível posicionar as torres mais próximas dos limites do lote em razão do desnível acentuado do terreno.*
Terreno	**Contaminação**	🟡	*A área em questão possui documentação disponível até a Fase 5, referente ao Plano de Intervenção para a descontaminação do terreno, porém não há registros que comprovem a execução das medidas propostas nem o sequenciamento das ações de remediação monitoramento. Diante disso, não é possível confirmar a reabilitação ambiental da área.*
Diferencial produto	**Faixa de renda**	2 e 3	
	Prime	Não	
	Supercondomínio	Não	
	Atributos Infra	Sim	*Quadra*
	Atributos Torre	Sim	*47% de varandas*
	Edifício Garagem	Não	

Pareceres

Análise da Mancha e Implantação

Prospecção

Operações

Inteligência de Mercado

Financeiro

Condições do Negócio – Francisco Velho

➢ **VALOR DO NEGÓCIO**

- R$ 9.700.000,00 (Nove milhões e setecentos mil reais) – equivalente a fração de aproximadamente 6,6%

OBS: Aproximadamente R$ 532/CA$_{LIQ}$ e R$ 1.118/m²

➢ **CONDIÇÃO**

- 100% Cash

➢ **FORMA DE PAGAMENTO**

- Sinal: R$ 500K (0,34% do VGV) pagos em uma única parcela fixa e irreajustável, em até 30 dias da superação das Resolutivas I com garantia por AF.
- Saldo: R$9.200.000[1] (Nove milhões e duzentos mil reais) em 36 parcelas mensais iguais que se iniciam a partir da lavratura da escritura.

[1] A título de adiantamento do Saldo do Preço, a COMPRADORA pagará parcelas semestrais fixas e irreajustáveis no valor de R$ 100.000 (cem mil reais), sendo a primeira paga no prazo de até 06 (seis) meses contados do envio de notificação comunicando a superação da res. I. Os valores antecipados serão diluídos nas parcelas do saldo. Em viabilidade foi considerado antecipação de 200k em virtude do prazo estimado para lavrar a escritura. Em contrato os pagamentos ocorrerão até que se supere as Res. II do contrato.

Obs.: O valor do ato +200k representam (0,48%) do VGV
No caso de distrato até a escritura as proprietárias permanecem com o valor de R$300.000 (trezentos mil reais) e devolvem a diferença das antecipações.

➢ **PRAZOS CONTRATUAIS**

- Tranche I – Até 4 meses da assinatura do CVC; Prev. Abr.26
- Tranche II - Em até 14 meses, prorrogáveis por mais 4, da superação da Tranche I, aprovação de projeto, contratação CEF e viabilidade técnica e financeira. Prev. Set.27

➢ **GARANTIAS**

- Tenda: Alienação Fiduciária de um dos imóveis no pagto do sinal e antecipações – estimativa total até a escritura de 700k (sinal 500K + 2 parcelas de antecipação de 100K)
- Vendedor: Seguro Garantia. (Taxa 0,30%)

➢ **CORREÇÃO MONETÁRIA**

- Saldo reajustado por IPCA (M-2) a partir da superação da Tranche II (incluindo escritura)

➢ **COMISSÃO**

- 5% do valor da aquisição - R$485.000, pagos um mês após a superação de todas as condições resolutivas e a escrituração do imóvel em 8 parcelas fixas e irreajustáveis.

➢ CONDIÇÕES RESOLUTIVAS:

I – Em até 04 (quatro) meses contados da data de assinatura deste Contrato: **(Prazo até abr/26)**

i. a existência de ação de desapropriação e/ou declaração de utilidade pública que objetive os Imóveis ou parte deles;

ii. a existência de cadastro como Imóveis tombados e/ou em processo de tombamento e/ou em áreas envoltórias, no IPHAN, CONDEPHAAT ou CONPRESP, que impossibilitem a adequada consecução do Empreendimento;

iii. a impossibilidade da realização do estudo de passivo ambiental ou a existência de qualquer tipo de contaminação do solo, subsolo e águas dos Imóveis, bem como qualquer outro tipo de passivo ambiental e/ou impossibilidade de remoção de árvores que comprometam o Empreendimento que a COMPRADORA pretende desenvolver nos Imóveis;

iv. a existência de óbice e/ou condições técnicas e/ou urbanísticas impeditivas à consecução do Empreendimento imobiliário almejado pela COMPRADORA;

v. a não apresentação dos documentos e/ou esclarecimentos, cuja obtenção somente seja possível por meio das VENDEDORAS ou por terceiro munido de procuração, relativos aos apontamentos existentes no prazo indicado ou a existência de qualquer apontamento nos documentos e certidões forenses que objetive, onere e/ou possa trazer vício à cadeia dominial dos Imóveis e/ou possa reduzir as VENDEDORAS ao estado de insolvência civil e/ou recuperação e/ou falência, ou que traga insegurança jurídica na operação objeto deste instrumento, a exclusivo critério da COMPRADORA;

vi. a não viabilidade das redes de água e esgoto existentes no local dos Imóveis, que sejam tidas como insuficientes a garantir a vazão necessária às unidades autônomas que comporão o Empreendimento pretendido;

vii. a não viabilidade de rede elétrica para abastecimento do futuro Empreendimento;

viii. a não viabilidade de execução da drenagem ou não permissão de passagem em terreno de terceiros;

ix. caso o gabarito de altura pretendido para o Empreendimento pretendido não seja aprovado no DECEA (Departamento de Controle do Espaço Aéreo) e COMAER (Comando da Aeronáutica);

i. não extinção das ações de usucapião sob nº 1079450-92.2025.8.26.0100 e 1090646-59.2025.8.26.0100

ii. CONDIÇÕES RESOLUTIVAS:

II – ETAPA II: Em até 14 (catorze) meses a contar da superação das condições descritas no item "I", supra, prorrogáveis automaticamente por mais 04 (quatro) meses, a critério da COMPRADORA (Prazo até nov/27)

i. a não celebração e apresentação de distrato dos Contratos de Locação e contrato de comodato, nos termos da cl. 4.5.2,contemplando a renúncia expressa ao direito de preferência pelos inquilinos, com base nas condições específicas para a venda acordadas entre as Partes nos termos do presente Contrato, e/ou seja constatada pela COMPRADORA a existência de terceiros ocupantes nos Imóveis, existindo pessoas e coisas, que impeçam a transferência da posse para a COMPRADORA de forma inteiramente livre e desimpedida, nos termos previstos no presente instrumento;

ii. a inviabilidade de regularização cadastral dos contribuintes dos Imóveis, com conversão da destinação de rural para urbano e/ou outras regularizações eventualmente verificadas que sejam capazes de interferir na consecução do Empreendimento Imobiliário pretendido pela COMPRADORA, nos termos da cláusula 1.3 e respectivos subitens;

iii. caso as partes não logrem promover eventuais regularizações relativas aos Imóveis, necessárias para a consecução do Empreendimento pretendido;

iv. o não aperfeiçoamento de quaisquer das condições resolutivas, relativas ao terreno e ao Empreendimento, abaixo relacionadas:

(a) Análise da viabilidade técnica e financeira do Empreendimento;

(b) Análise da viabilidade comercial do Empreendimento;

(c) Verificação da manutenção da segurança jurídica, contemplando a análise das certidões das VENDEDORAS e dos Imóveis, nos termos da cláusula 3.5, supra.

i. a não renovação do alvará autorizando a venda do Imóvel, em virtude de exigências formuladas pelo tabelionato de notas indicado pela COMPRADORA para a lavratura da Escritura de Compra e Venda dos Imóveis, na forma da cláusula 1.2.2, supra;

ii. a não aprovação nos termos da legislação vigente do projeto do Empreendimento junto à Prefeitura Municipal e demais órgãos competentes, necessários para viabilizar sua edificação, mediante a obtenção de todas as licenças necessárias para tal fim e/ou exigências pela Prefeitura Municipal de obrigações adicionais não contempladas no projeto apresentado e/ou de contrapartida que acarrete a inviabilidade financeira do Empreendimento pretendido pela COMPRADORA;

iii. a inviabilidade de contratação de financiamento pela instituição financeira para construção do Empreendimento, consoante os termos e condições do Programa do Governo Federal Minha Casa Minha Vida ou qualquer outro que venha a substituí-lo;

➢ OUTRAS INFORMAÇÕES:

- Na hipótese de serem detectados por meio dos estudos ambientais a serem realizados pela COMPRADORA dentro do prazo previsto no item I da cláusula 6.1, infra, quaisquer Passivos Ambientais nos Imóveis que atinjam ou sejam capazes de atingir e/ou colocar em risco a consecução do Empreendimento, fica a COMPRADORA desde já autorizada pelas VENDEDORAS a contratar, a seu exclusivo critério, estudos complementares, se necessário, para fins de confirmar as medidas que deverão ser adotadas visando sanar os referidos passivos, caso em que os prazos contratuais ficarão suspensos, sem penalidades para as Parte, até a conclusão dos referidos estudos. Uma vez concluídos os estudos ambientais, inclusive complementares, e confirmada a necessidade de adoção de medidas visando sanar os Passivos Ambientais, fica a COMPRADORA autorizada a adotar as medidas para sanar os referidos passivos arcando com as respectivas despesas, sob suas exclusivas expensas, até o limite de R$ 400.000,00 (quatrocentos mil reais), valor contemplado na viabilidade. Caso as despesas para sanar os Passivos Ambientais seja superior ao referido limite, as Partes deverão, antes do início de qualquer procedimento, definir conjuntamente, dentro do prazo de até 30 (trinta) dias a contar de notificação a ser enviada pela COMPRADORA às VENDEDORAS, a parte que ficará responsável pelo pagamento das respectivas despesas excedentes, observado o previsto nas Cláusulas 3.7.1.1. e 3.7.1.2., infra

- Pareceres
- Análise da Mancha e Implantação
- Prospecção
- Operações
- Inteligência de Mercado
- Financeiro

Comitê

	FRANCISCO VELHO CEN02 | R02	FRANCISCO VELHO CEN02 | R01	ENEAS CAMARGO II CEN. 02 | R03	TÓQUIO CEN 03 | R03
Torres	5	5	4	4
Unidades Construídas	620	620	760	780
Unidades Vendidas	612	612	751	763
Total Unidades Vendidas	612	612	751	763
Condomínios (qta.)	1	1	1	1
Cidade	São Paulo - SP	São Paulo - SP	São Paulo - SP	São Paulo - SP
Produto / Selo	CDW V0200 F2E MODULAR	CDW V0200 F2E MODULAR	CDW V0200 F2E MODULAR	CDW F2E MODULAR
Tipologia	1 Torre | T+09 | 08PP	1 Torre | T+09 | 08PP	1 Torre | T+09 | 18PP	1 Torre | T+09 | 16PP
Tipologia	1 Torre | T+09 | 12PP	1 Torre | T+09 | 12PP	1 Torre L | T+09 | 18PP	2 Torres | T+09 | 20PP
Tipologia	2 Torre em L T+09 | 12PP	2 Torre em L T+09 | 12PP	2 Torres | T+09 | 20PP	1 Torre | T+09 | 22PP
Tipologia	1 Torre | T+09 | 18PP	1 Torre | T+09 | 18PP	-	-
Atributos de Projeto	288 Varandas	288 Varandas		144 Varandas + Piscina
Projeto Infra	AP	AP	AP	AP
Projeto Torre	AP/EM	AP/EM	AP / EM	AP
Mês Base	setembro-25	setembro-25	agosto-25	setembro-25
Incc	1.222,356	1.216,706	1.191,327	1.216,706
LVS	julho-25	julho-25	abril-25	junho-25
Indiretos	julho-25	julho-25	abril-25	julho-25
Base de Preço	LPU 96	LPU 94	LPU 92	LPU 94
Takt	2x2	2x2	2x2	2x2
Prazo (mês)	22	22	25	22
CUSTO TOTAL I	R$ / UND R$ 99.451	R$ / UND R$ 105.722	R$ / UND R$ 99.914	R$ / UND R$ 96.563
Indireto	R$ 19.399	R$ 20.115	R$ 17.828	R$ 18.236
Torre	R$ 55.819	R$ 57.207	R$ 53.510	R$ 56.122
Infra	R$ 13.399	R$ 13.364	R$ 14.356	R$ 13.117
Fundação	R$ 7.506	R$ 8.147	R$ 7.628	R$ 8.039
EEE	R$ 616	R$ 616	R$ 508	
ETE			R$ 1.843	
Contenção	R$ 1.559	R$ 1.619	R$ 2.258	R$ 103
Terraplenagem	R$ 1.153	R$ 4.654	R$ 1.983	R$ 947
CUSTO TOTAL II	R$ 5.204	R$ 5.203	R$ 1.227	R$ 1.790
Urbanização	R$ 659	R$ 658	R$ 98	R$ 200
Drenagem				
Extensão de Rede Elétrica	R$ 245	R$ 245	R$ 160	R$ 103
Extensão de Rede Hidráulica	R$ 4.300	R$ 4.300	R$ 970	R$ 1.487
CUSTO TOTAL III				
Incorridos				
CUSTO TOTAL IV				
Aprendizado				
CUSTO TOTAL V		R$ 515	R$ 2.634	R$ 457
Atualização por INCC		R$ 515	R$ 2.634	R$ 457
CUSTO TOTAL I+II	R$ 104.655	R$ 110.924	R$ 101.141	R$ 98.353
CUSTO TOTAL I AO IV	R$ 104.655	R$ 111.439	R$ 103.776	R$ 98.810

Operações

SISTEMA DE ABASTECIMENTO DE ÁGUA
Existe viabilidade técnica para abastecimento de água. Necessário realizar um extensão na rede de 280m aproximadamente (Opção 1 da Diretriz).

SISTEMA DE ESGOTAMENTO SANITÁRIO
Existe viabilidade técnica para abastecimento de esgoto. Necessário realizar uma extensão na rede de 433m aproximadamente. (Opção 2 da Diretriz)

SISTEMA DE DRENAGEM
Descarte na rede pública em frente ao terreno por gravidade.

SISTEMA DE ABASTECIMENTO DE GÁS
Abastecimento por GLP.

SISTEMA DE ABASTECIMENTO ELÉTRICO
Não Existe viabilidade técnica.

TERRENO

URBANIZAÇÃO

Operações

Matriz Risco Concessionária	
Água	Nível 3
Esgoto	Nível 3
Drenagem	NA
Elétrica	Nível 5
Gás	NA
Urbanização	Nível 3

LEGENDA		
Nível	Tipo	Status
1	Com Diretriz	Conclusiva
2		Conclusiva com projeto aprovado
3		Conclusiva sem projeto aprovado
4		Não Conclusiva
5	Sem Diretriz	-
NA	-	Não aplicável

Água:
- Viabilidade emitida em 09/2025, com validade em 09/2027.

Esgoto:
- Viabilidade emitida em 09/2025, com validade em 09/2027.

Drenagem:
- Descarte na via pública na Rua Francisco Velho.

Elétrica:
- Não existe viabilidade. No pedido de ligação definitiva a concessionária pode vir a cobrar reformas necessárias, caso a infraestrutura existente não seja suficiente.

Gás:
- Não se aplica. Empreendimento com GLP.

Urbanização:
- Entorno do empreendimento com vias asfaltadas. Há necessidade de nova execução das calçadas em todo perímetro do empreendimento.

Fundação:
- Realizada campanha de sondagem contemplando 02 furos. Necessário sondagem complementar.
- Considerada Estaca Hélice, com diâmetros de 40, 50, 60 e profundidade de 14, à 20m.

Logística

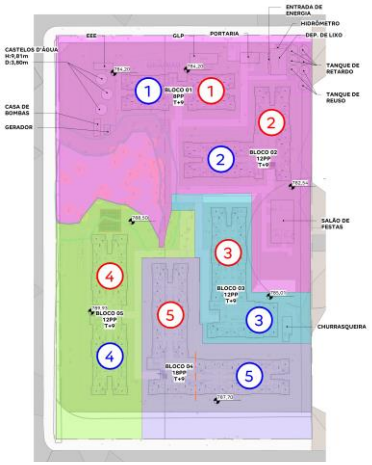

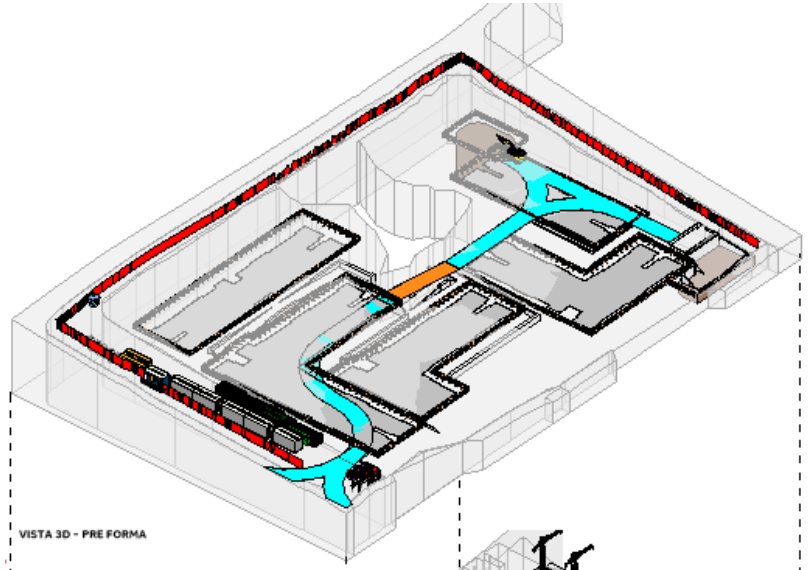

VISTA 3D - PRE FORMA

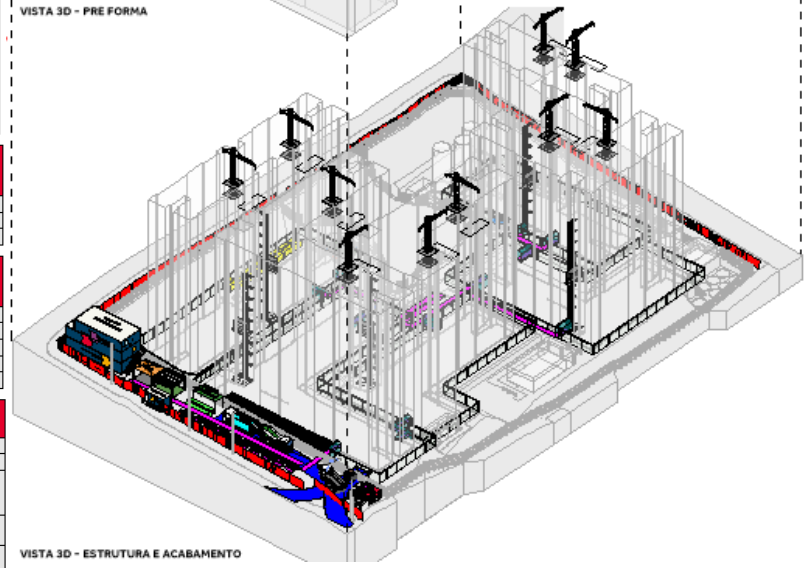

VISTA 3D - ESTRUTURA E ACABAMENTO

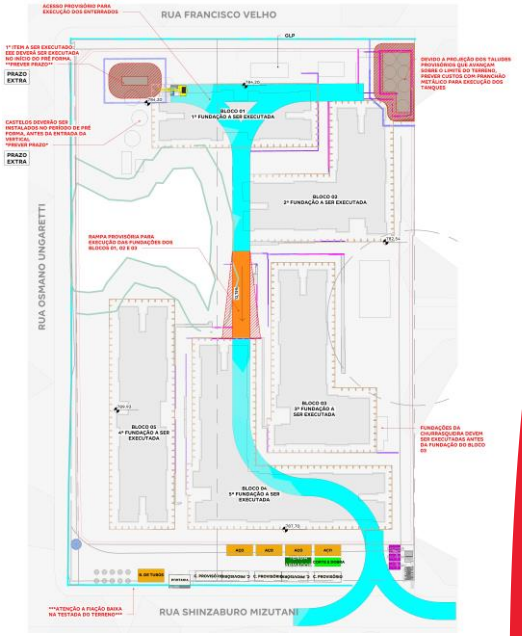

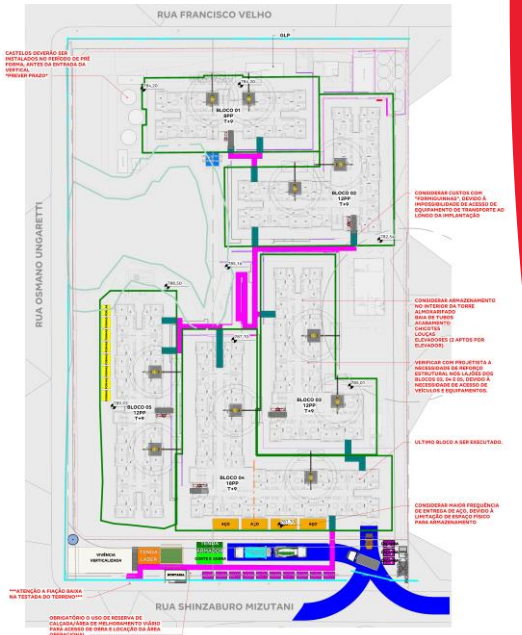

VIVÊNCIA - CONTAINERS								
DESCRIÇÃO	QUANTIDADE	TAMANHO MÓDULOS	MOBILIZAÇÃO	DESMOBILIZAÇÃO	PRÉ FORMA	ESTRUTURA	ACAB.	FASE
CONTAINER PORTARIA (LOG)	CONSIDERAR 1 MÓDULO DE CONTAINER	2,41m X 4,90m	1 MOB	1 DESMOB	TODO PERÍODO	TODO PERÍODO	TODO PERÍODO	
CONTAINER PROVISÓRIO (LOG)	CONSIDERAR 8 MÓDULOS DE CONTAINER	2,41 X 6,10 m	1 MOB	1 DESMOB	TODO PERÍODO	-	-	
CONTAINER VIVÊNCIA VERTICALIZADA (LOG)	7 MÓDULOS DE CONTAINER EMBAIXO, 7 MÓDULOS EM CIMA	2,41 X 6,10 m	1 MOB	1 DESMOB	-	TODO PERÍODO	TODO PERÍODO	

LOG_LAZER							
DESCRIÇÃO	QUANTIDADE	MOBILIZAÇÃO	DESMOBILIZAÇÃO	PRÉ FORMA	ESTRUTURA	ACABAMENTO	FASE
FUMODROMO PEQUENO (LOG)	1	-	-	TODO PERÍODO	TODO PERÍODO	TODO PERÍODO	
TENDA LAZER	1	-	-	-	TODO PERÍODO	TODO PERÍODO	

TENDAS_PERÍODOS							
DESCRIÇÃO	QUANTIDADE	LARGURA	COMPRIMENTO	PRÉ FORMA	ESTRUTURA	ACABAMENTO	FASE
TENDA ARMADOR (LOG)	1	2,00	6,00	TODO PERÍODO	TODO PERÍODO	-	
TENDA ARMADOR (LOG)	1	2,50	6,00	TODO PERÍODO	TODO PERÍODO	-	
TENDA BANHEIRO QUÍMICO E BEBEDOURO (LOG)	1	3,00	3,00	-	TODO PERÍODO	TODO PERÍODO	
TENDA MOLDADOR (LOG)	1	2,00	3,00	TODO PERÍODO	TODO PERÍODO	-	

LOG_EQUIPAMENTOS E MAQUINÁRIOS							
EQUIPAMENTO	QUANTIDADE	MOBILIZAÇÃO	DESMOBILIZAÇÃO	PRÉ FORMA	ESTRUTURA	ACABAMENTO	FASE
BETONEIRA (LOG)	VARIÁVEL	-	-	TODO PERÍODO	TODO PERÍODO	-	
BOBCAT (LOG)	1 EQUIPAMENTO	1 MOBILIZAÇÃO	1 DESMOBILIZAÇÃO	-	TODO PERÍODO	CONSIDERAR 15 DIAS DO PERÍODO DE ACABAMENTO	
BOMBA ESTACIONÁRIA PADRÃO (LOG)	1 EQUIP PARA O BLOCO X	-	-	-	TODO PERÍODO	-	
CAMINHÃO MUNCK (LOG)	1 EQUIPAMENTO	1 MOBILIZAÇÃO	1 DESMOBILIZAÇÃO	-	CONSIDERAR MEIO PERÍODO DE ESTRUTURA	-	
CREMALHEIRA CABINE DESMONTÁVEL (LOG)	3 EQUIPAMENTOS	1 MOB DE CREMALHEIRA POR TORRE (TAKT 2X2)	1 DESMOB DE CREMALHEIRA POR TORRE (TAKT 2X2)	-	TODO PERÍODO	TODO PERÍODO	
ESCAVADEIRA (LOG)	1 EQUIPAMENTO	1 MOB	1 DESMOB	CONSIDERAR DURANTE O PERÍODO DE TERRAPLENAGEM	-	-	
MINIGRUA (LOG)	2 EQUIPAMENTOS	1 MOB POR MINIGRUA POR TORRE (TAKT 2X2)	1 DESMOB POR MINIGRUA POR TORRE (TAKT 2X2)	-	TODO PERÍODO	-	

Pareceres

Análise da Mancha e Implantação

Operações

Inteligência de Mercado

Financeiro

Anexo

Mancha de Demanda

MANCHAS DE DEMANDA

• SZL – São Paulo Leste

Lançamento

1. Tucumã
2. Oásis Penha
3. Viva Parque do Carmo
4. Reserva das Andorinhas
5. Palermo
6. Alvorada Aricanduva

LandBank

7. Florença
8. Lar de Itaquera | Sol de Itaquera
9. Viva Azul
10. Solar da Araucária
11. Jerivás
12. Amarilis
13. Marechal Tito
14. Francisco Velho

Cluster MPR – (Comitê)

Cluster 2 - Amarelo

Região

Capital

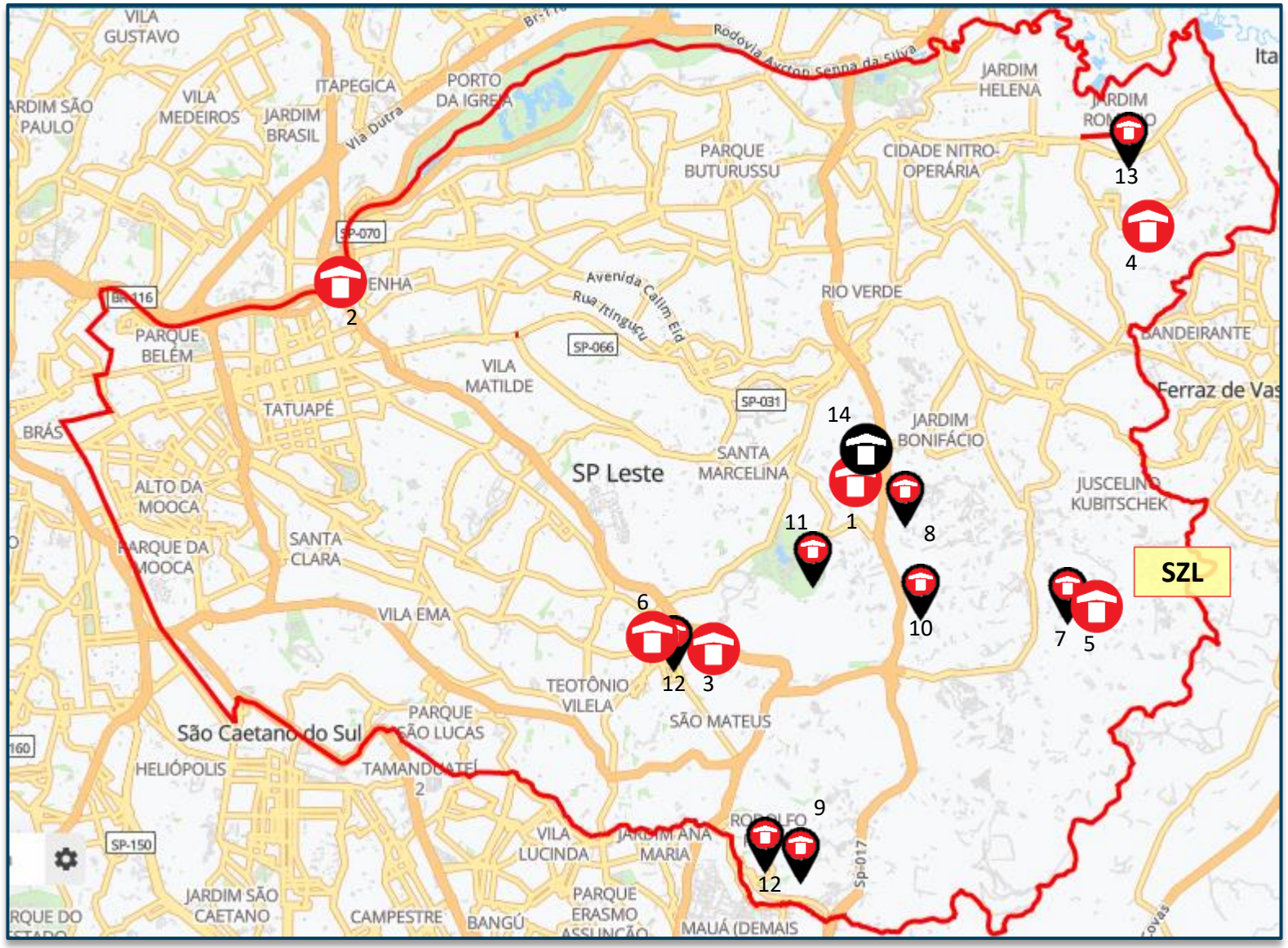

Lançados *LandBank* *Comitê*

Demanda e Distribuição da Mancha

Potencial de Demanda			Lançados		Lanç + Landbank	
Mancha	CÓD.	Shr.	ANO	MÊS	ANO	MÊS
São Paulo Leste	SZL	30%	3.669	306	4.403	367

Faixas MCMV	Empreendimento	Renda	Lançamento	nov/27	dez/27	jan/28	fev/28	mar/28	abr/28	mai/28	jun/28	jul/28	ago/28	set/28	out/28	nov/28	dez/28	jan/29	fev/29	mar/29	abr/29	mai/29	jun/29	jul/29	ago/29
Faixa 2	Residencial Quioto	2.938	jul-26	38	38	38	38	8																	
Faixa 1	Florença	2.771	set-26	37	3																				
Faixa 2	Amarilis	3.034	dez-26	54	54	54	54	54	54	54	54														
Faixa 2	Jerivas	3.530	fev-27	50	50	50	50	50	50	50	50	50	50												
Faixa 2	Marechal Tito	3.486	jul-27	34	34	34	34	34	34	34	34	34	34	34	34	34	34	27							
Faixa 2	Etelvina (Aurora)	3.874	ago-27	21	21	21	21	21	21	21	21	21	21	21	21	21	21	21	21	21	5				
Faixa 2	**Francisco Velho**	**4.086**	**nov-27**		**34**	**34**	**34**	**34**	**34**	**34**	**34**	**34**	**34**	**34**	**34**	**34**	**34**	**34**	**34**	**34**	**34**	**34**			
Faixa 2	Residencial Tóquio	2.889	jan-28				43	43	43	43	43	43	43	43	43	43	43	43	43	43	43	43	43	32	
Faixa 1	Viva Azul F1	2.838	out-28													63	63	63	63	63	63	63	63	63	63
Faixa 2	Viver - Lar De Itaquera	3.094	jun-29																					53	53
Total de Vendas Lançados				**0**	**0**	**0**	**0**	**0**	**0**	**0**	**0**	**0**	**0**	**0**	**0**	**0**	**0**	**0**	**0**	**0**	**0**	**0**	**0**	**0**	**0**
Total de Vendas Lançados + Landbank				**234**	**234**	**231**	**274**	**244**	**236**	**236**	**236**	**182**	**182**	**132**	**132**	**195**	**195**	**188**	**161**	**161**	**145**	**140**	**106**	**148**	**116**
Total Mancha | Faixa 1				*16%*	*1%*	*0%*	*0%*	*0%*	*0%*	*0%*	*0%*	*0%*	*0%*	*0%*	*0%*	*32%*	*32%*	*34%*	*39%*	*39%*	*43%*	*45%*	*59%*	*42%*	*54%*
Total Mancha | Faixa 2				*84%*	*99%*	*100%*	*100%*	*100%*	*100%*	*100%*	*100%*	*100%*	*100%*	*100%*	*100%*	*68%*	*68%*	*66%*	*61%*	*61%*	*57%*	*55%*	*41%*	*58%*	*46%*
Total Mancha | Faixa 3				*0%*	*0%*	*0%*	*0%*	*0%*	*0%*	*0%*	*0%*	*0%*	*0%*	*0%*	*0%*	*0%*	*0%*	*0%*	*0%*	*0%*	*0%*	*0%*	*0%*	*0%*	*0%*

Parecer de I.M sobre a mancha:

O projeto analisado em comitê está em linha com o potencial teórico de demanda calculado para a mancha. (Total Lanç + Landbank)

Canibalização:

Sem Risco de Canibalização

Francisco Velho | Mapa Concorrência

		Francisco Velho	Meu Plano&Parque Do Carmo
		TENDA	Plano & Plano
	Distância Tenda (km)		1km
Região 1 Km	População	24.075	15.488
	Dens. Demográfica	7.713	4.962
	Renda (R$)	4.791	4.590
	Classe Social	C1 (de R$ 3.1K a 5.4K)	C1 (2.7k a 4.6k)
	PEA Dia	17.935	11.596
Quantitativo	Lançamento	nov/27	set/24
	Unidades	612	2.463
	Estoque	612	210
	VSO	34	150
	Stockout	18	1
Qualitativo	Condomínios	1	1
	Torres	4	7
	Gabarito	T+9	T+9
	Plantas (m²)	32,3m² e 33m²	32,18m²
	Tipologia	2 Dorms	Não
	Opções	Não	Não
	Varanda	Sim	Não
	Vagas	Sem Vaga	Sem Vaga
	Lazer	Espaço Office, Fitness, Salão de Festas, Brinquedoteca, Praça de Chegada, Churrasqueira Gourmet, Play Pet, PlayKids, Play Baby e Funcional Externo.	Churrasqueira, Playground, Piscina Adulto e Infantil, Pet Care, Mini Mercado, Salão de Festas, Mini Quadra, Brinquedoteca, Fitness/Funcional, Salão de Jogos, Espaço Influencer, Delivery, Coworking, Espaço Bem Estar, Sala de Ginástica.

Farol Renda
Acima de 300
Entre 0 e 300
Abaixo de 0

Diagnóstico Concorrência

- Apesar do concorrente Meu Plano & Parque do Carmo, possuir preço competitivo previsto para o Produto Tenda, o projeto não possui flexibilidade na negociação com TCD, capturando tudo em preço raso, perdendo competitividade frente ao produto Tenda nas unidades Faixa 2.
- A Plano lançou o projeto posicionando 81% das unidades no Faixa 1, e recentemente migrou todas as unidades para Faixa 2. Até o momento não temos liberação de novas vendas no Faixa 1, podendo essas serem liberadas sem prévio aviso para o mercado, **vale destacar a Tenda já atua na região com os projeto Alvorada Aricanduva e Viva Parque do Carmo e captura os preços e rendas estimados no parecer**.

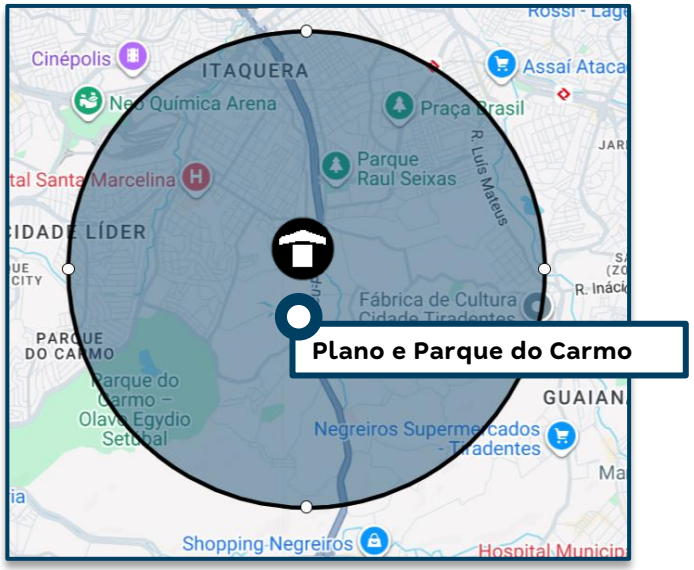

-	Francisco Velho					Meu Plano&Parque Do Carmo				
Tipologias	Avaliação	Preço Nominal	CEF	Renda	% Unidades	Preço Nominal	CEF	Renda	% Unidades	Farol
Uh Tipo - Faixa 1						199.188	159.350	2.640	81%	-
Uh Tipo	255.000	231.461	186.557	3.728	53%	222.464	191.129	3.850	19%	●
Varanda	280.000	249.940	203.606	4.488	47%					

Francisco Velho – Mapa Sociodemográfico

Polos de Atratividade

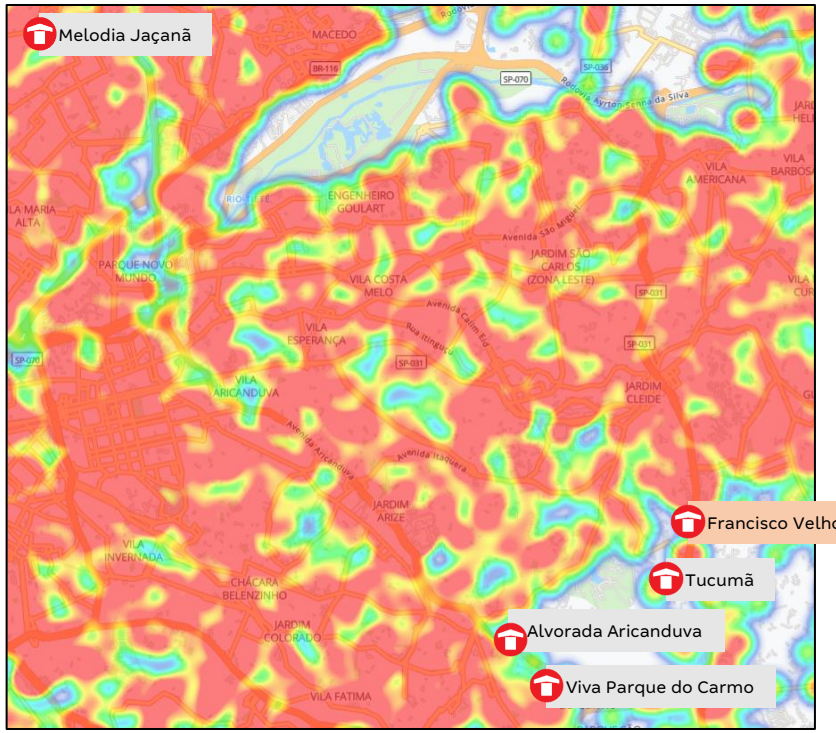

PEA/Dia

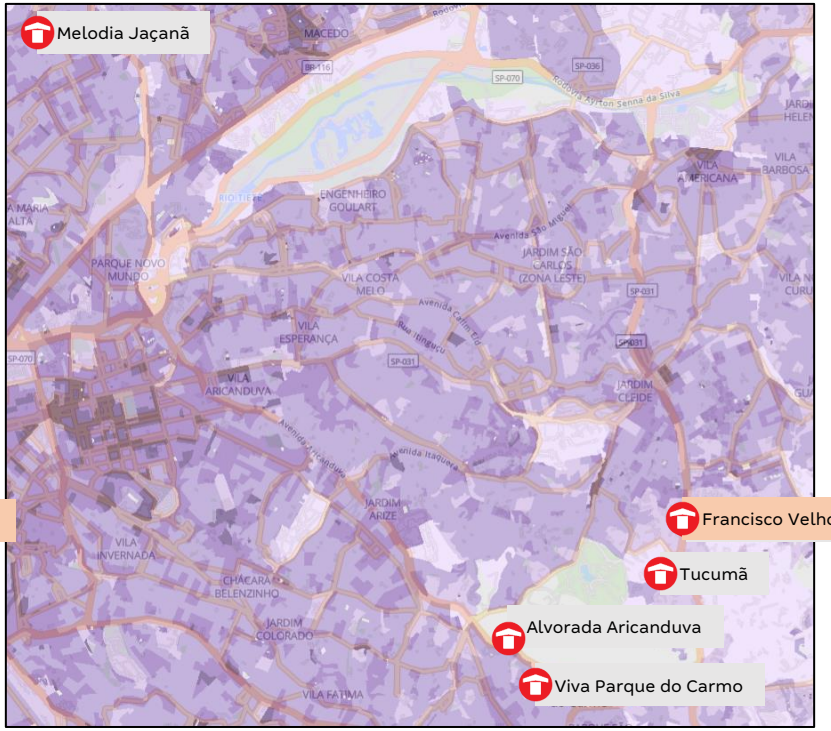

Renda Média

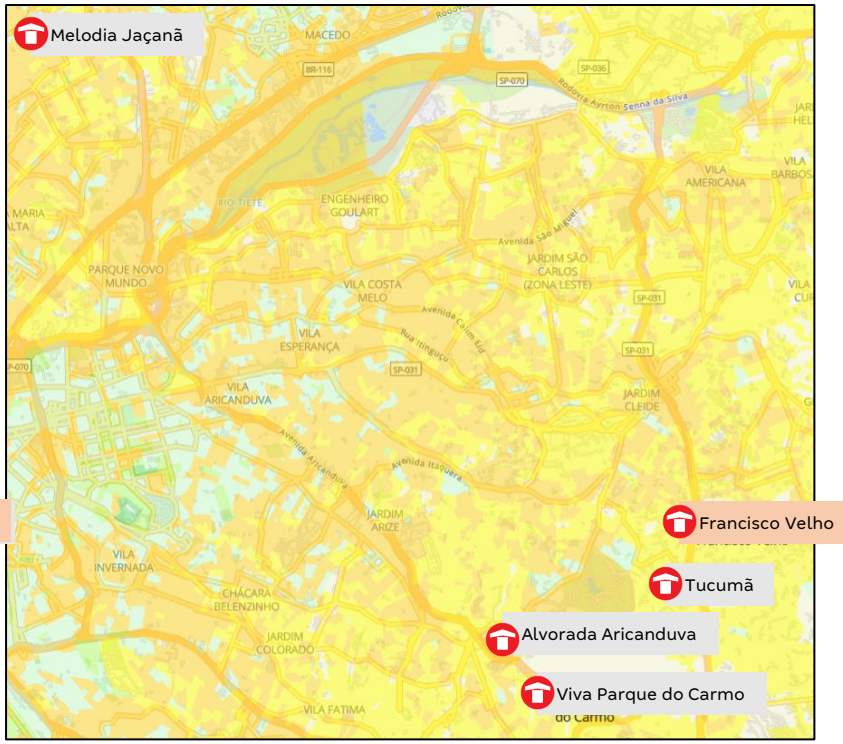

Observamos através dos mapas acima que a região do Francisco Velho, apesar da maior proximidade com Tucumã, em dados, se compara mais a região do Vista Parque do Carmo.
Projeto contará com atributos de Varanda como diferencial, e possui baixa concorrência local.

Simulação de Preço

Informações Viabilidade

Projeto:	Francisco Velho			
Tipo:	**Uh Tipo**		**Uh Tipo**	
Método	**Ref - Alv. Aricanduva**		**Vision**	
Avaliação	255.000		255.000	
Renda Inicial (VF)	3.788		3.728	
Renda Final*	-		-	
% RET1	0%		0%	
Tipo:	**VF**	**R$**	**VF**	**R$**
Ato	0,50	1.901	0,53	1.953
FGTS	0,74	2.796	0,80	2.977
Financiamento	97,77%	178.028	95,94%	177.402
Subsídio	253,77%	5.526	275,34%	6.179
Prazo de Pró-soluto	27	27	27	27
Pró-Soluto	63,69%	23.667	63,76%	23.318
Preço Raso (RS)	211.917	211.917	211.828	211.828
TCD	41,08%	15.683	52,25%	19.633
VSO	18	18	18	18
Preço de Venda	**228.756**	**228.756**	**232.636**	**232.636**
Elasticidade	-0,505%	-0,505%	-0,505%	-0,505%
Preço de Venda Final	**227.601**	**227.601**	**231.461**	**231.461**
Preço Raso (R$)	**211.917**		**211.828**	
% de Raso	**93,11%**		**91,52%**	
BP25 - Não Inflacionado	**-**		**-**	
BP25 - Inflacionado	**-**		**-**	

Informações Viabilidade

Projeto:	Francisco Velho	
Tipo:	**Varanda**	**Varanda**
Método	**Ref - Alv. Aricanduva**	**Vision**
Avaliação	280.000	280.000
Renda Inicial (VF)	-	4.488
Renda Final*	-	-
% RET1	-	0%

Tipo:		VF	R$
Ato	O projeto **Alvorada Aricanduva** não teve vendas de unidades com varanda.	0,62	2.768
FGTS		0,70	3.126
Financiamento		100,26%	200.480
Subsídio		0,00%	0
Prazo de Pró-soluto		27	27
Pró-Soluto		64,19%	28.261
Preço Raso (RS)		234.635	234.635
TCD		33,83%	15.305
VSO		16	16
Preço de Venda		**251.209**	**251.209**
Elasticidade		-0,505%	-0,505%
Preço de Venda Final		**249.940**	**249.940**
Preço Raso (R$)		**234.635**	
% de Raso		**93,88%**	
BP25 - Não Inflacionado		**-**	
BP25 - Inflacionado		**-**	

Análise de Preço

Informações Viabilidade

Projeto:	Francisco Velho	
Tipo:	**Faixa 2**	
Método	**Vision**	
Avaliação	266.765	
Renda Inicial (VF)	4.086	
Renda Final*	-	
Tipo:	**VF**	**R$**
Ato	0,57	2.336
FGTS	0,75	3.047
Financiamento	97,98%	188.262
Subsídio	145,77%	3.271
Prazo de Pró-soluto	27	27
Pró-Soluto	63,96%	25.644
Preço Raso (RS)	222.560	222.560
TCD	43,58%	17.596
VSO	34	34
Preço de Venda	**241.370**	**241.370**
Elasticidade	-0,505%	-0,505%
Preço de Venda Final	**240.157**	**240.157**
Preço Raso (R$)	**222.560**	
% de Raso	**92,67%**	
Raso Todas as Fases	**222.560**	
Nominal Todas as Fases	**240.157**	

1

Análise de Riscos	Farol IM
IM avalia o Preço Vision como **factível**.	

1) O projeto está inserido em uma região consolidada, onde já atuamos com os empreendimentos Alvorada Aricanduva, Viva Parque do Carmo e Tucumã, sendo o Alvorada a principal referência. O preço e a renda estimados pelo Vision estão alinhados ao praticado no Alvorada para as unidades tipo, com uma renda média geral ligeiramente superior em função da precificação das unidades com varanda.

	Preço Real					Preço Normalizado (27m)	
	Avaliação	Preço Raso	Renda Mediana	VSO	PSOL	Δ PSOL	Preço Raso
Palermo	236.667	197.079	2.561	21	25	1.810	198.889
Tucumã	235.023	202.299	3.489	19	27	0	202.299
Reserva Das Andorinhas	231.600	200.212	3.071	12	21	4.362	204.574
Alvorada Aricanduva	248.158	216.516	3.788	11	33	-4.973	211.543
Viva Parque Do Carmo	237.768	206.387	3.741	35	20	5.880	212.267
Francisco Velho	266.765	222.560	4.086	34	27	-	222.560
Oásis Penha	287.962	259.958	5.286	36	33	-7.156	252.803

Análise Concorrência

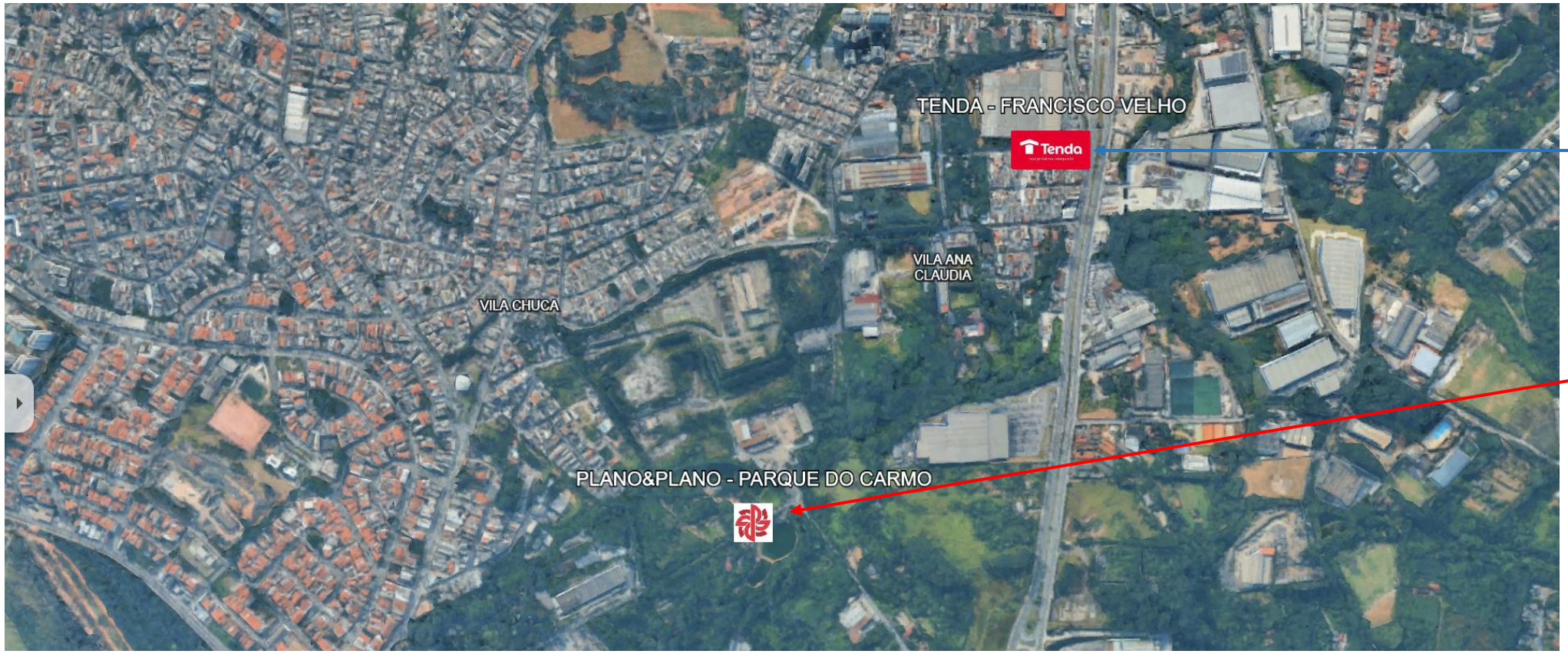

TENDA
FRANCISCO VELHO

PLANO&PLANO
PARQUE DO CARMO
900 METROS

Análise Concorrência

Concorrência 1

Incorporadora: Plano&Plano

Inf. Produto	Parque do Carmo
Data Lanç	06/09/2024
Qtde de unidade	2.463
Estoque	673
Renda Apartir	4.590
Tipologias	HIS 2

Preço	
31,70m² S/Varanda S/Vaga	225.426
32,19m² C/Varanda C/Vaga	243.634
-	-
-	-
-	-

Fluxo	
Ato	200
30/60/90	-
Prazo Pró-Soluto	36 meses
% Pró-Soluto	30%
Prazo Intermediaria	3
% Intermediaria	10%
ITBI/TCD	Sim Cobra
% Parcela TCD	-
Correção	Não Cobra

Parecer Ciclo

O Ciclo validou o **preço** e o **VSO** como viáveis.

O projeto está localizado em uma região onde temos **grande penetração de mercado** por meio dos nossos canais:

- **EV:** 120 imobiliárias ativas
- **TV:** Matriz na Zona Leste
- **House:** 4 lojas (Tatuapé e Itaquera)

Ponto de atenção: volume elevado de lançamentos da P&P, que tradicionalmente pratica preços bastante agressivos.

- Pareceres
- Análise da Mancha e Implantação
- Prospecção
- Operações
- Inteligência de Mercado
- Financeiro

Informações Gerais – Consolidado

Fco Velho – SP – São Paulo Capital

Datas e Prazos

	Compra	Lançamento	Início Obra	Término Obra	LÇTO até IO	IO até TO	Chaves	LÇTO até Chaves
Consolidado	dez-25							
HMP		nov-27	mai-28	mar-30	6 meses	22 meses	nov-30	36 meses
HMP - Varanda		nov-27	mai-28	mar-30	6 meses	22 meses	nov-30	36 meses

Terreno e Incorridos

TOTAL (R$ + Perm.):	9,70 MM	**Incorrido Terreno:**	0,00 MM	**Área do Terreno (100%):**	9.662 m²	**Área Líquida do Terreno:**	8.676 m²
Cash:	9,70 MM	**Nº de Parcelas Cash :**	39	**Custo de terreno m²:**	1.003,9	**Custo de terreno m² Área Líquida:**	1.118,0
Permuta Financeira:	0,00 MM (0,00%)			**VaR 25 (R$ mil):**	0	**Fração Terreno/Terreno + Custo Obra (%VGV):**	6,6% / 50,2%
Permuta Física:	0,00 MM (0,00%)			**VaR 26 (R$ mil):**	600	**CA Máx/Proj.**	4,1 / 2,1
Ato / %VGV:	0,70 MM / 0,5%			**Incorrido de Construção:**	0,00 MM	**Incorridos de Incorporação:**	0,05 MM

Vendas

Fases	Nº Pavimentos	Preço Raso Unit.	Qtde	Preço Unit.	Aval. CEF	Cond. Parcela	% Pró-soluto	% TCD
HMP	T+9	211.828	324	231.461	255.000	95,9%	63,8%	52,2%
HMP - Varanda	T+9	234.635	288	249.940	280.000	100,3%	64,2%	33,8%

Unidades Totais:	612	**Preço Médio:**	240.157	**Renda Média:**	4.086	**ITBI+Emol. Unit. Médio:**	4.921
Unidades Tenda:	612	**Avaliação Média:**	266.765	**Ato:**	2.331 (0,57 Salários)	**Custo do Ciclo Unit.:**	15.118
VSO:	34 Unidades	**VGV Total:**	146.976.024	**FGTS:**	3.082 (0,75 Salários)	**Preço Raso Médio:**	222.560
RET Médio:	4,0%	**VGV Tenda:**	146.976.024	**% em RET 1%:**	0%	**Adc. Tx. de Aceleração Médio:**	750

Construção

Custo Total Unit.:	104.655	**Eventuais:**	4,00%	**Área priv (m²):**	32,95	**Gape / Mês Unit.:**	11,08

Resultado

LI (R$):	**16.944.422**	**LI:**	**20,33%**	**Exposição de Caixa (R$):**	**19.675.302**	**Margem Bruta Econômica:**	**39,63%**
TIR:	**101,63%**	**LI Aprovação:**	**20,00%**	**Ger. Caixa 12 meses (R$):**	**(600.000)**	**Margem Bruta REF:**	**42,93%**
Exposição de Caixa:	**12,30%**	**Δ LI:**	**0,33%**	**Ger. Caixa 24 meses (R$):**	**(3.289.390)**	**Margem Rasa Econômica:**	**34,25%**
Payback Contingente (21 m):	**20 m/ (-1 m)**	**LI Resiliência:**	**11,93%**	**Ger. Caixa Marginal (R$):**	**41.029.612**	**Margem Rasa REF:**	**38,43%**
Payback Consolidado:	**20 meses**					**Margem de Contribuição Econômica:**	**28,02%**

DRE (Consolidado)

R$ Mil - Valores Nominais - Compra	Fco Velho		HMP		HMP - Varanda	
	Nominal	%	Nominal	%	Nominal	%
Receita	159.988	100,0%	81.876	100,0%	78.112	100,0%
PIS/COFINS	(3.509)	2,2%	(1.796)	2,2%	(1.713)	2,2%
Custo Total	(94.465)	60,4%	(50.093)	62,6%	(44.372)	58,1%
Custo Terreno	(10.372)	6,6%	(5.491)	6,9%	(4.881)	6,4%
Custo Relacionados a Terreno	(1.412)	0,9%	(748)	0,9%	(665)	0,9%
Custos de Incorporação	(3.778)	2,4%	(2.083)	2,6%	(1.696)	2,2%
Custo de Construção	(78.902)	50,4%	(41.772)	52,2%	(37.130)	48,6%
Lucro Bruto Econômico	62.013	39,6%	29.986	37,4%	32.027	41,9%
Custo para Rateio	-	0,0%	-	0,0%	-	0,0%
Lucro Bruto Contábil	62.013	39,6%	29.986	37,4%	32.027	41,9%
Despesas de Selling	(14.484)	9,3%	(6.694)	8,4%	(7.790)	10,2%
Contingência	(3.680)	2,4%	(1.883)	2,4%	(1.797)	2,4%
Margem de Contribuição	43.849	28,0%	21.409	26,7%	22.440	29,4%
IR e CSLL	(2.871)	1,8%	(1.469)	1,8%	(1.402)	1,8%
Margem Líquida	40.978	26,2%	19.940	24,9%	21.038	27,5%
Lucro Bruto REF Unit.	115.336	42,9%	105.612	40,8%	126.275	45,2%
Lucro Raso REF Unit.	95.681	38,4%	83.676	35,3%	109.186	41,6%

R$ Mil - VPL - Compra	Fco Velho		HMP		HMP - Varanda	
	VP	%	VP	%	VP	%
Receitas	83.345	100,0%	42.384	100,0%	40.961	100,0%
PIS/COFINS	(1.801)	2,2%	(916)	2,2%	(885)	2,2%
Custos e Despesas Totais	(64.599)	77,5%	(33.610)	79,3%	(30.989)	75,7%
Custo Terreno	(6.188)	7,4%	(3.276)	7,7%	(2.912)	7,1%
Custo Relacionados a Terreno	(932)	1,1%	(494)	1,2%	(439)	1,1%
Custos de Incorporação	(2.300)	2,8%	(1.271)	3,0%	(1.029)	2,5%
Custo de Construção	(43.709)	52,4%	(23.140)	54,6%	(20.569)	50,2%
Despesas de Selling	(9.009)	10,8%	(4.175)	9,9%	(4.834)	11,8%
Contingência	(988)	1,2%	(506)	1,2%	(482)	1,2%
IR e CSLL	(1.473)	1,8%	(749)	1,8%	(724)	1,8%
Lucro Imobiliário	16.944	20,3%	7.858	18,5%	9.087	22,2%

Análise da Mancha e Implantação

Prospecção

Operações

Inteligência de Mercado

Financeiro

Pareceres

Anexos

Obrigado