Tenda

sua próxima conquista

Book de Investimento – **Comitê Ampliado**

Regional: RMSP – Guarulhos

Projeto: Brumatti Santos

Data Comitê: 08/12/2025

One Page – Brumatti x Santos

Destaques

[1]

Cidade	Guarulhos	Mancha de demanda	SPRM - GRU - Guarulhos
Regional	SPRM	Cluster MPR	2 - Amarelo
Cenário de Aprovação	Aprovação	Tipo de Aprovação	Consolidado
Fase Anterior	N/A		
Tipo de Comitê	Investimento	Versão da VF	Versão 1.0: Dez

[2]

Unidades (Fases)	1092 (2)	CA Máx | Proj	3,5 | 1,9
Unidades com Vaga (%)	423 (39%)	Escritura | Lançamento	mai/27 | jun/27
Unidades com Varandas (%)	516 (47%)	Tipologia	F2E Plus - CDW

[3]

Valor Líquido do Terreno (% VGV)	19.634 (7,3%)	Un. Perm. Fís (% Ter)	0 (0,0%)
Cash (Correção)	3.927 (IPCA)	%VGV Perm Fin Líquida (% Ter)	4,4% (77,4%)
Valor R$/m²	1.063	VAR (%VGV)	000 (0,0%)

[4]

Custo Construção (%VGV)	119.090 (44,3%)	Indireto Unit.	17.200
Prazo da Obra (meses)	22	Torre Unit.	57.201
Custo Total Unit. | Corrigido (LPU):	109.057 | 108.765 (97)	Infra Unit.	14.119
Início de Obra	dez-27	Fundação Unit.	5.291

[5]

Preço Nominal Unit.	246.303	VSO	30
Preço Raso Unit.	226.264	Referência	Vision
Avaliação Unit.	254.759	Renda (% em RET 1%)	3.811 (27,7%)

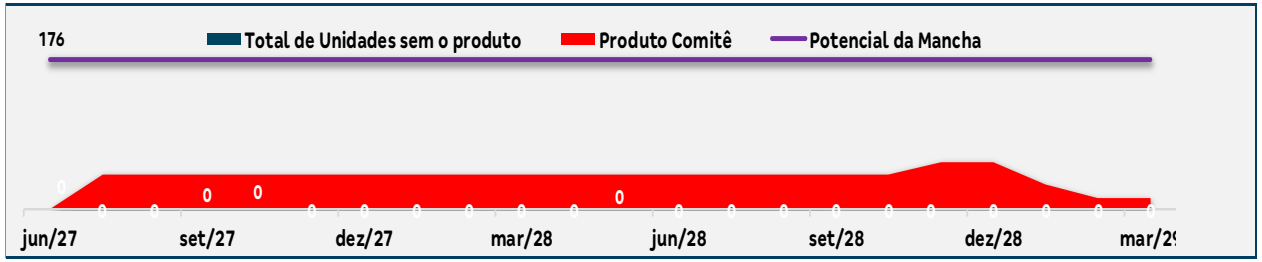

[6]

LI (Régua):	20,0% (20,0%)	Margem Bruta Econômica:	38,6%
LI Resiliência:	12,7% (N/A)	Margem Rasa Econômica:	32,5%
Margem Bruta REF:	42,1%	Margem Contribuição Econômica:	27,4%
Margem Rasa REF:	37,0%	Exposição (% VGV):	25.678 (8,8%)
TIR:	105,4%	VGV Total:	268.963
Payback Contingente (21 m) :	21 m/ (0 m)	Ger. Caixa 12 meses (R$):	-
Payback Consolidado:	21	Ger. Caixa 24 meses (R$):	(11.571)

Comitê Ampliado tem o objetivo de aprovar 100% do projeto, baseado na conclusão dos estudos técnicos com elaboração de AP (ante projeto) incluindo Edif. Garagem, parametrização, diretrizes, e due diligence. Manutenção das demais condições estabelecidas no comitê essencial de 22/09/25

[1] Localização: Está na Av. José Brumatti em **Guarulhos (RMSP)**, onde nossa última baixa para LB foi em 2021 (Bonsucesso/Prados).

[2] Implantação: Terreno com área líquida de 16.337,79m2, com 1.092 uh com 47% de varanda em cada torre, 365 vagas de carro (exigência mínima de 1/3), em duas fases de lançamento F1 com 754 uh (20pp T+18), 281 vagas, e F2 com 338 uh (20pp T+16), 84 vagas carro, 58 vagas moto distribuídas nas fases. Temos restrição de gabarito contemplada no estudo por conta do aeroporto, com limitação variada no terreno em função da cota de implantação x cone de aproximação do aeroporto. Com a inclusão do ed. garagem tivemos um acréscimo de 33% no número de unidades.

[3] Condição Comercial:
Valor do Negócio: R$ 19.633.000 – Aprox. R$1.319/m2 e R$ 566/CA atingido sob a área líquida.

a) 20% em cash em 4 parcelas iguais e sucessivas de 981 mil reais, iniciando na escritura, total de R$ 3.926.600, corrigidas por IPCA a partir da escritura;
b) 80% em perm. financeira equivalente a 5% do VGV líquido; será descontado 12% no fluxo de pagamento, representando 4,4% do VGV bruto; sendo o PMG (sobre a permuta) de R$ 15.706.400 com prazo para apuração em 44 meses após o registro da escritura com correção do saldo por IPCA a partir da escritura;
c) Garantia: Confissão de dívida ou seguro garantia a escolha das vendedoras (com custo de contratação a ser descontado das parcelas inicias de participação);

[4] Custo de obra: Custo total de R$ 109.057/uh; o Edifício Garagem gerou um custo total incremental por unidade de R$ 11,4K, e um custo por vaga de ~ R$ 27,48K; Obs: o Ed Garagem de GRU é menos eficiente do que SAE, pois necessita de 100% das vagas soltas.

[5] Preço de Venda: Referência de Preço do Jd. Prados, indicam oportunidade de ganhos, tendo em vista a avaliação do Ciclo de uma localização superior; projeto contempla varanda com delta preço de R$16K; provável oportunidade de preço nas vagas que estão precificadas no ponderado (coberta/descoberta) em 26K.

[6] Resultado: Resultado consolidado entrega LI régua, porém fase 1 é impactada desproporcionalmente em função da alocação do custo total do edifício garagem.

Pareceres

Análise da Mancha e Implantação

Prospecção

Operações

Inteligência de Mercado

Financeiro

Anexos

Pareceres

Área	Riscos Associados	Parecer	Criticidade
Jurídico	Ao concluirmos a Due Diligence, constatamos que, embora tenha sido apresentada Certidão Positiva com Efeitos de Negativa em nome da VENDEDORA PRICILA FIORDELÍSIO DE CARVALHO, consta débito de R$ 3.117,97. Referida quantia deverá ter sua quitação acompanhada até a data de lavratura da escritura. Não constaram apontamentos relevantes em relação aos demais vendedores. Até o momento não foi constatado nenhum tipo de gravame ou ônus na matrícula do imóvel. Constam débitos de IPTU no valor de R$ 368.392,63, que serão quitados pela vendedora até a data de lavratura da escritura. O imóvel segue locado para fins comerciais, por prazo indeterminado, sendo que sua desocupação ocorrerá até a data de lavratura da escritura, o que precisa ser acompanhado pela companhia. Constatada a existência de processo de usucapião nº 0078627-11.2012.8.26.0224, ingressado pelo vizinho, solicitando parte do imóvel, tendo como base demarcação anteriormente elaborada. Após a conclusão das análises, com a realização de novo levantamento técnico e topográfico, é possível confirmar que não tem relação com a área objeto da presente aquisição. Desta forma, conclui-se que, no momento, do ponto de vista jurídico, não há óbices que comprometam a presente transação.	Ok com ressalvas	
Legalização	Alargamento da calçada, seguindo diretriz da Prefeitura, absorvido em AP. Solicitada nova diretriz urbanística e nova diretriz de Sabesp com os números corretos de uhs. Necessária a avaliação confirmatória de contaminação. Há possibilidade de ocorrência pontual de metais, já considerada na viabilidade e tratada por meio de impermeabilização. Laudo arbóreo identificou um maciço arbóreo em um talude com alta declividade, como estratégia de negócios, decidimos pela não intervenção neste local. Demais estudos técnicos realizados como sondagem e COMAER não apresentam ponto de atenção.	Ok	
Produto	Ok, sem ressalvas	Ok	
GETEC	Sem Riscos	Ok	
Logística	Sem riscos associados; Necessário ressaltar o uso da Doação Institucional é obrigatório para realização do projeto.	Ok com ressalvas	
Inteligência de mercado	IM avalia o Preço Vision como factível.	Ok	
Comercial/Ciclo	O Ciclo validou o preço e o VSO como viáveis. O projeto está estrategicamente localizado em melhor região de Guarulhos que o Jd. dos Prados (Bonsucesso). A área apresenta forte potencial de demanda e, mesmo diante da presença de concorrentes, estamos com preços competitivos. Além disso, já observamos ganhos de aprox. 25mil nas vagas descobertas do Prados, corroborando para oportunidade de ganhos futuros.	Ok	
Estudos Econômicos	Não há.	Ok	

Pareceres

Análise da Mancha e Implantação

Prospecção

Operações

Inteligência de Mercado

Financeiro

Anexos

Mancha de Demanda

MANCHAS DE DEMANDA
• GRU – Guarulhos
1. Jd. Bonsucesso + Jd. Dos Prados
2. Brumatti

Cluster MPR – (Comitê)
Cluster 2 - Amarelo

Região
Região Metropolitana

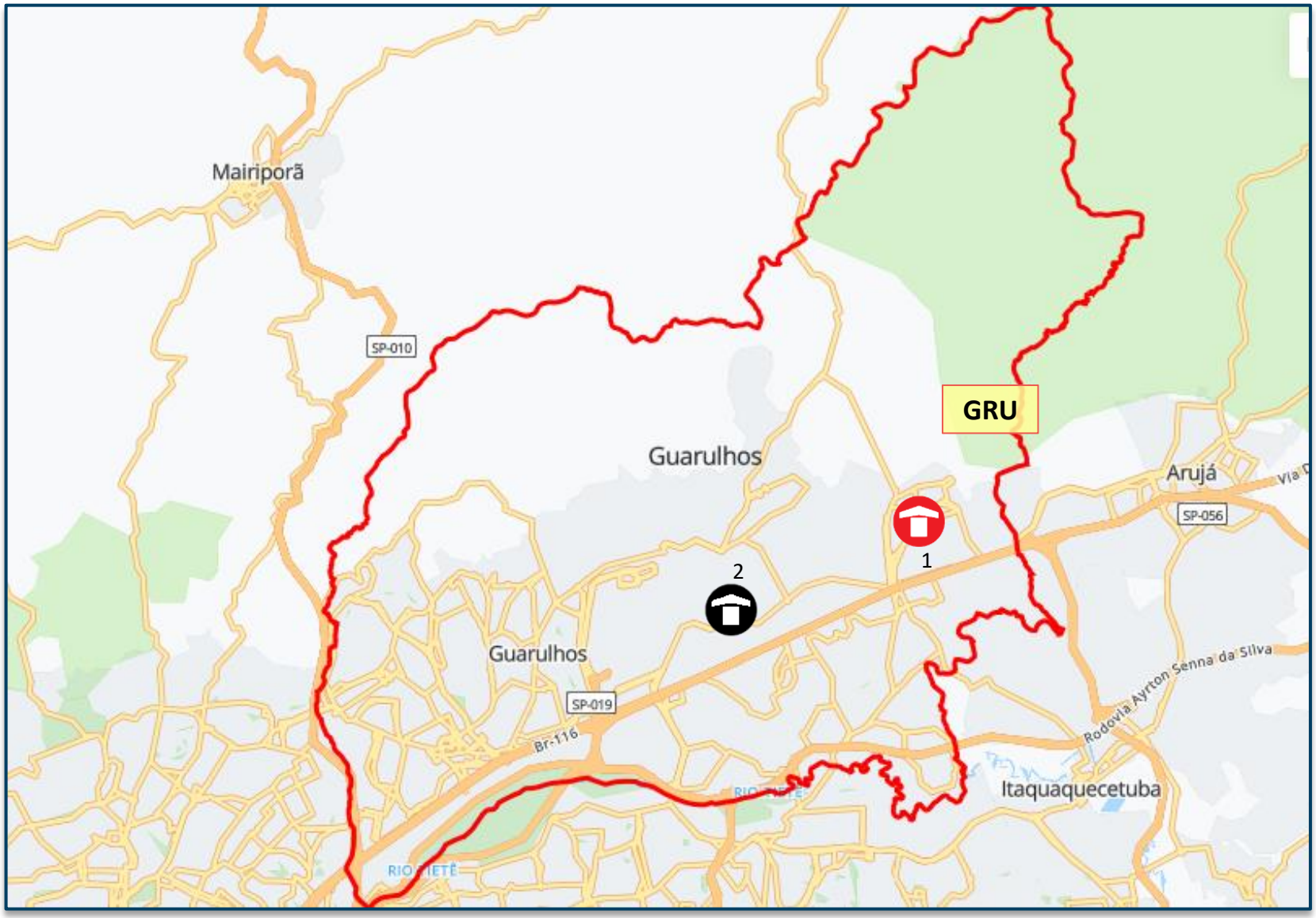

Lançados *LandBank* *Comitê*

Localização – Av. José Brumatti – Guarulhos - SP

Supermercados Nagumo - Lavras

Escola Manoel Bomfim

Escola Estadual Profª Idalina Ladeira Ferreira

Residencial lavras – Toth Construtora

Grife Transportadora

TENDA – Jardins de Guarulhos

Golden Plaza MRV

Escola Estadual Deputado José Storópoli

Localização – Av. José Brumatti – Guarulhos - SP



Av. José Brumatti

Área Total

Empreendimento Brumatti Santos
Investimento

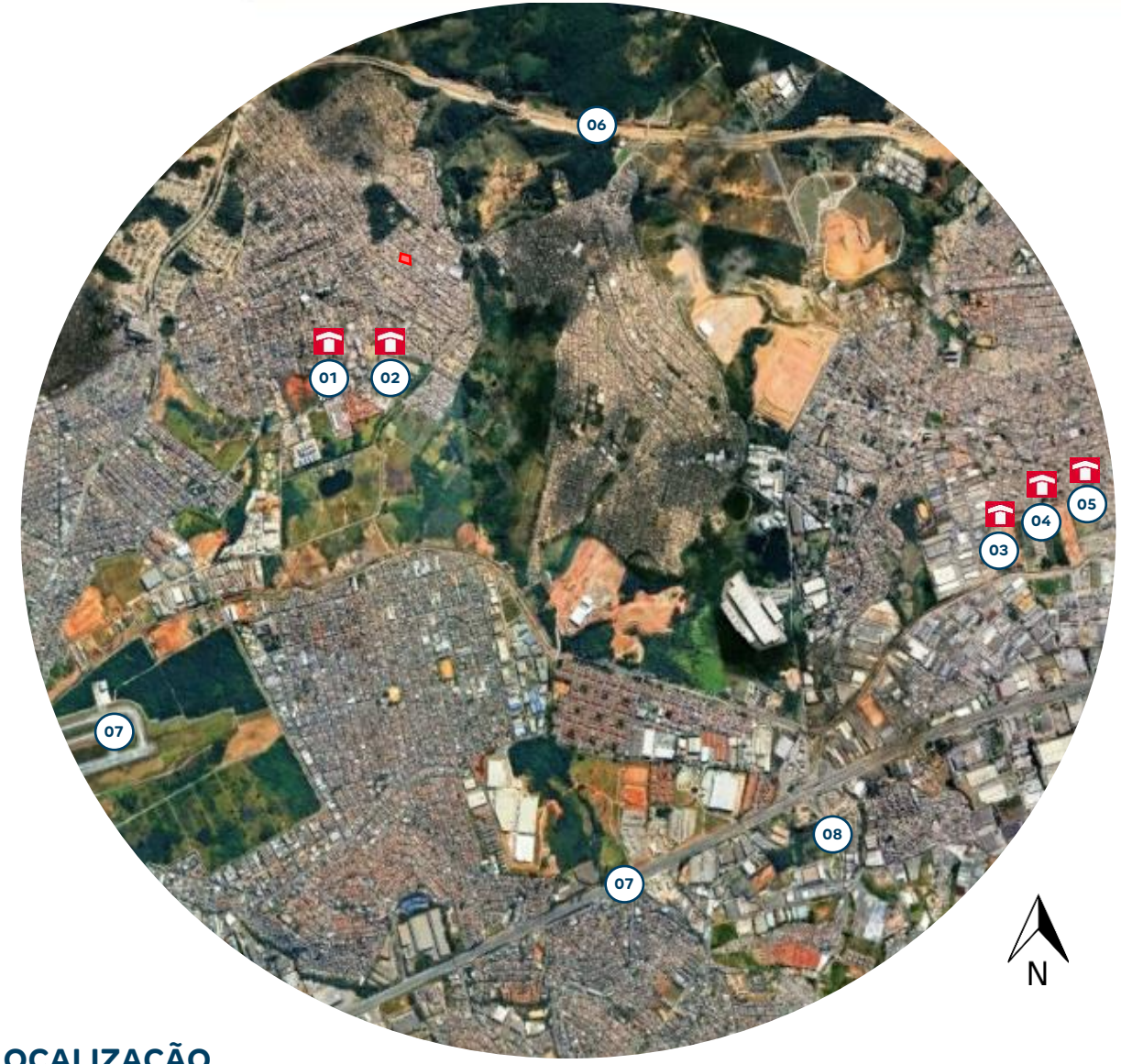

Legenda:

01 **Brumatti Santos – Guarulhos**

02 Jardins - Guarulhos (650m)

03 Amantikir e Tarumã - Guarulhos (6,9km)

04 Estância das Flores – Guarulhos (7,2km)

05 Jardim Bonsucesso e Jardim dos Prados – Guarulhos (7,1km)

06 Shopping Bonsucesso (7,0km)

07 Aeroporto de Guarulhos (15km)

08 Previsão Rodoanel Mario Covas

09 Rodovia Presidente Dutra

POLIGONAL DO TERRENO

LOCALIZAÇÃO

AVENIDA CIDADE DE SANTOS

Empreendimento Brumatti Santos
Investimento

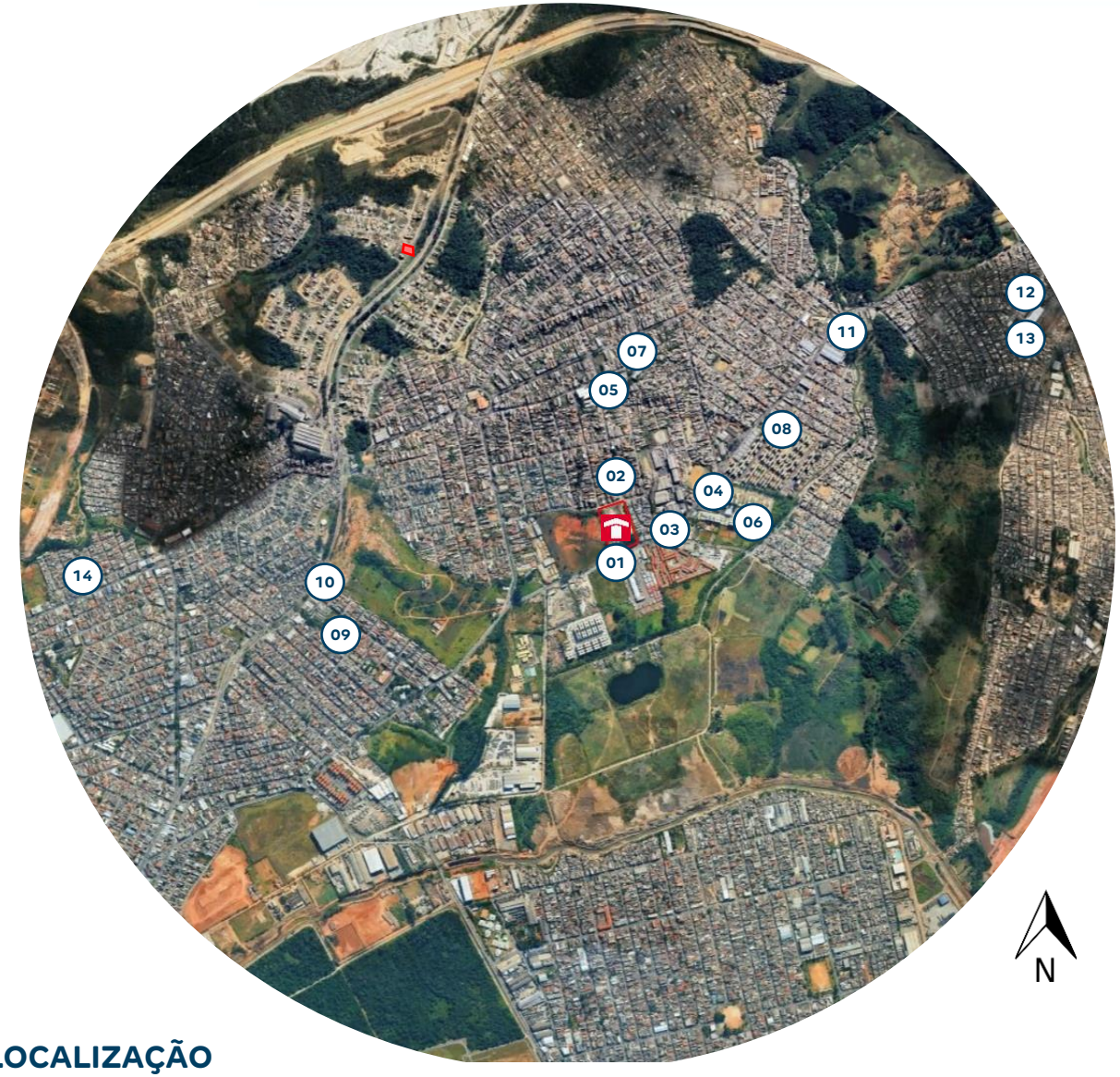

LOCALIZAÇÃO

Legenda:

01 **Brumatti Santos**

02 ONG – Instituto de Cidadania Sol Encantado - Instituição Educacional (0,02) km

03 Ponto de Ônibus (0,15 km)

04 Supermercado Nagumo (0,30 km)

05 UBS Soberana – Centro Médico Público (0,40 km)

06 Farma 22 – Drogaria (0,42 km)

07 Escola Estadual Professora Idalina Ladeira Ferreira – Escola Pública (0,50 km)

08 EPG Manoel Bomfim – Escola de Ensino Fundamental (0,75 km)

09 Parque Santa Terezinha (1,08 km)

10 Posto Ipiranga (1,10 km)

11 Faculdade Anhanguera Polo Guarulhos (1,10 km)

12 Teatro Ponte Alta (1,73km)

13 Centro de Educação Unificado (1,80 km)

14 Creche Guiando (2,05km)

TERRENO

AVENIDA CIDADE DE SANTOS

PRODUTO

Empreendimento Brumatti Santos
Investimento

Informações Gerais

Terreno	**Área terreno**	19.633,45m²
	Menor poligonal	18.651,52m²
	App/Fna	Não/Não
	Maciço Vegetal	2.313,92m²
	Doação Institucional (5%)	982,12m²
	Reserva de calçada/ melhoramento viário	Não
	Área liquida	16.337,79xm²
Diretrizes Urbanísticas	**Zoneamento**	ZUD – 4
	Ca máximo Total	3,50
	Ca básico	2,00
	Ca projetado	1,86
	Ca líquido	2,33
	Gabarito máximo	Cota 821 (COMAER)
Geral	**Total uh**	1.092
	Total de vagas exigido	398 (Sendo 364 carros - 33% , 22 visitantes – 5%, 8 PCD – 2%, 1 CD*, 2 ED*) 55 (5,00% - Motos)
	Total de vagas projetado	399 (Sendo 365 carros – 33%, 22 visitantes – 5%, 8 PCD – 2%, 1CD*, 2 ED* 58 (5,31% - Motos)
Tipologia	**Tipologia**	V0200
	Gabarito	T + 16 | T + 18
	Lâmina	03 20 pp
	Área privativa	32,03m²
Condomínio	**Unidade pcd**	110
	Unidade lazer|técnica	04|03
	Torre	03
	Varanda	520 unidades (47,6%)
	Fase	02
Lazer	**Lazer Interno**	01-Salão de Festas Gourmet, 02-Espaço Office.
	Lazer Externo	03-Churrasqueira Gourmet, 04-PlayBaby, 05 – PlayKids, 06 – PetPlace, 07 – Bicicletário, 08 – Quadra de Street Ball, 09 – Praça dos Sabores, 10- Multipla Estação

Varanda

CD* **Vaga de carga/ descarga**

ED* **Vaga de embarque/ desembarque**

01 **Doação Institucional:** Destinação de 5% da área total do terreno, conforme diretriz urbanística.

02 **Maciço Vegetal:** Vegetação secundária em estágio inicial de regeneração.

Restrições de Adensamento:

- **Gabarito do COMAER**
- **Área de doação institucional**
- **Área com declividade alta voltada para a Av. José Brumatti**
- **Área de maciço vegetal**

PRODUTO

Empreendimento Brumatti Santos
Investimento

	Descrição	Criticidade	Observação
Usabilidade	**Acesso Empreendimento**		
	Percurso do pedestre até torre		*Desnível de 7,88 m entre o acesso e a última torre, vencido por meio de rampas.*
Diferencial produto	**Faixa de renda**	02	
	Prime	Não	
	Supercondomínio	Sim	*1.092 unidades*
	Atributos Infra	Sim	*Quadras*
	Atributos Torre	Sim	*Varanda em cada uma das faces da torre*
	Edifício Garagem	Sim	***T+4 - Cobertas: 273 vagas comuns,*** *22 visitantes, 08 PCD, 55 motos.* ***Descobertas: 92 vagas comuns*** *e 03 motos*

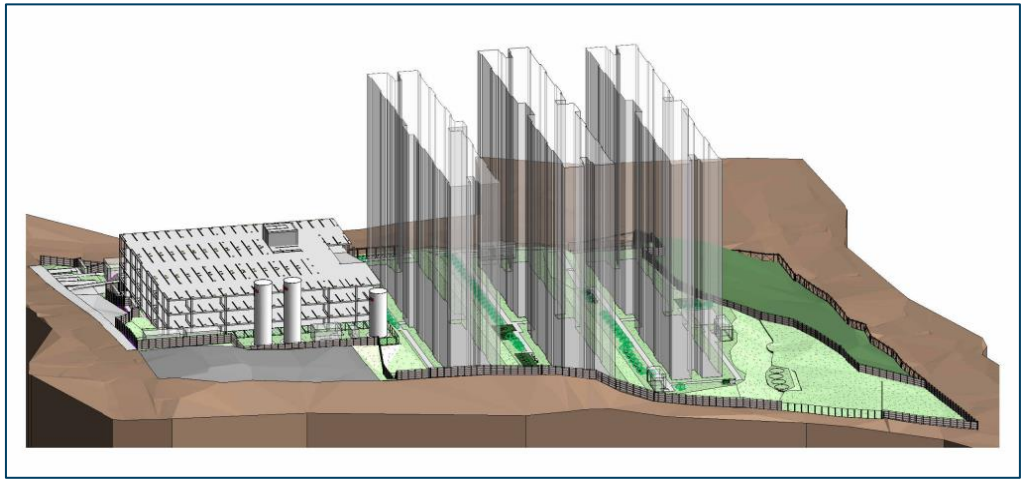

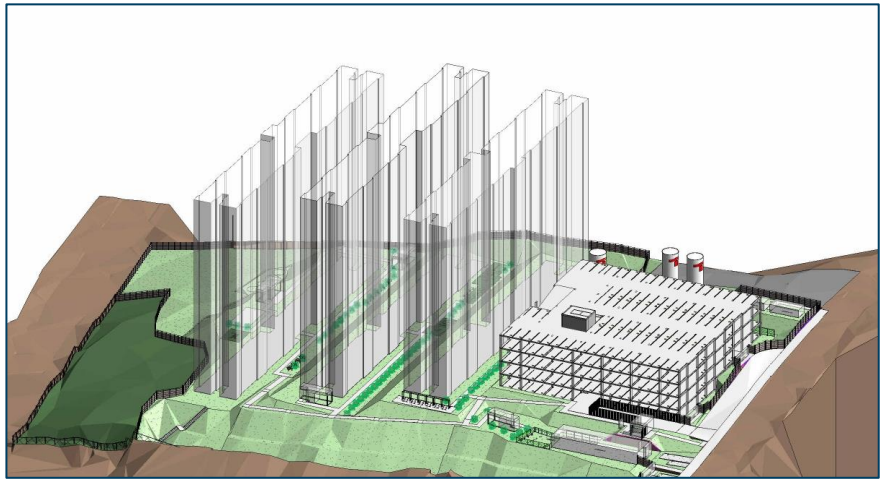

Pareceres

Análise da Mancha e Implantação

Prospecção

Operações

Inteligência de Mercado

Financeiro

Anexos

Condições do Negócio

➢ VALOR DO NEGÓCIO / CONDIÇÃO COMERCIAL

- **Valor do Negócio: R$ 19.633.000 –** Aproximadamente R$ 1.319/m2 e R$ 566/CA atingido (indicadores sobre a área líquida)

A) 20% em cash em 4 parcelas iguais e sucessivas de 981 mil reais, iniciando na escritura;

B) 80% em Permuta financeira equivalente a 5% do VGV líquido; será descontado o percentual de 12% no fluxo de pagamento da permuta. Na viabilidade este valor representa atualmente 4,4% do VGV líquido, sendo PMG (sobre a permuta) de R$ 15.706.400 com prazo para apuração em 44 meses após o registro da escritura com correção do saldo por IPCA a partir da data da escritura.

Obs: O valores (itens A e B) serão reajustados pelo IPCA a partir da escritura.

➢ PRAZOS CONTRATUAIS

- Etapa I: Em até 180 dias da assinatura do contrato para resolutivas técnica, jurídica e financeira; (limite mar/26)
- Etapa II: Em até 45 dias após a superação da Etapa I para notificação do inquilino referente ao direito de preferência; (limite mai/26)
- Etapa III: Em até 18 meses após a superação da Etapa II para aprovação de projeto, contratação CEF, análise técnica, financeira e comercial para o lançamento do empreendimento; (limite nov/27)

➢ GARANTIAS

- Proprietário: Confissão de dívida ou seguro garantia a critério das vendedoras (no caso de contratação do seguro o custo será descontado das parcelas inicias de participação) – estamos considerando na VF que seguiremos com a confissão de dívida.
- Tenda: N/A.

➢ CORRETAGEM

- 6% do valor do negócio a ser pago pela Tenda: R$ 1.177.980 em 5 parcelas após a escritura fixas e irreajustáveis.

Pareceres

Análise da Mancha e Implantação

Prospecção

Operações

Inteligência de Mercado

Financeiro

Anexos

Comitê

	BRUMATTI SANTOS FASE 01	BRUMATTI SANTOS FASE 02	BRUMATTI SANTOS CEN 01 | R00 – CONSOLIDADO	CUIABINHO CEN 02 | R01	PQ ANHANGUERA CONSOLIDADO | R11	BELA VISTA JARAGUA CEN. 07 | R05 CONSOLIDADO
Torres	2	1	3	2	4	3
Unidades Construídas	760	340	760 | 340	504	1.292	1.140
Unidades Vendidas	754	338	754 | 338	499	749 | 522	749 | 377
Total Unidades Vendidas	754	338	1.092	499	1.271	1.126
Condomínios (qta.)	1	1	1	1	1	1
Cidade	Itaquaquecetuba - SP	Itaquaquecetuba - SP	Itaquaquecetuba - SP	Itaquaquecetuba - SP	São Paulo - SP	São Paulo - SP
Produto / Selo	F2E - V0200 CDW	F2E - V0200 CDW	F2E - V0200 CDW	F2E - V0200 CDW	F2E - V0200 CDW	F2E - V0200 CDW
Atributos	360 Varandas	160 Varandas	520 Varandas	-	180 + 90 Varandas	360 Varandas
Tipologia	2 Torres | T+18 | 20PP		2 Torres | T+18 | 20PP	2 Torres | T+18 | 14PP	2 Torres | T+18 | 20PP	3 Torres | T+18 | 20PP
Tipologia		1 Torres | T+16 | 20PP	1 Torres | T+16 | 20PP	-	1 Torre | T+18 | 18PP	-
Tipologia	-	-	-	-	1 Torre | T+18 | 10PP	-
Projeto Infra	AP	AP	AP	AP	AP	AP
Projeto Torre	AP	AP	AP	AP	AP	AP
Mês Base	novembro-25	novembro-25	novembro-25	novembro-25	outubro-25	outubro-25
Incc	1.225,633	1.225,633	1.225,633	1.222,356	1.218,747	1.218,747
LVS	outubro-25	outubro-25	outubro-25	setembro-25	agosto-25	agosto-25
Indiretos	outubro-25	outubro-25	outubro-25	setembro-25	agosto-25	agosto-25
Base de Preço	LPU 97	LPU 97	LPU 97	LPU 96	LPU 95	LPU 95
Takt	2x2	2x2	2x2	2x2	2x2	2x2
Prazo (mês)	22	16	22 | 16	19	25 | 20	25 | 20
CUSTO TOTAL I	R$ / UND R$ 97.447	R$ / UND R$ 91.182	R$ / UND R$ 95.508	R$ / UND R$ 104.893	R$ / UND R$ 96.958	R$ / UND R$ 93.988
Indireto	R$ 16.468	R$ 18.836	R$ 17.200	R$ 20.814	R$ 18.734	R$ 17.116
Torre	R$ 57.649	R$ 56.203	R$ 57.201	R$ 56.573	R$ 58.051	R$ 57.457
Infra	R$ 15.772	R$ 10.431	R$ 14.119	R$ 18.204	R$ 13.255	R$ 12.026
Fundação	R$ 5.167	R$ 5.569	R$ 5.291	R$ 6.699	R$ 6.171	R$ 5.035
EEE				R$ 756		R$ 369
ETE						
Contenção	R$ 255		R$ 176	R$ 127	R$ 174	R$ 267
Terraplenagem	R$ 2.137	R$ 144	R$ 1.520	R$ 1.721	R$ 572	R$ 1.718
CUSTO TOTAL II	R$ 2.148	R$ 2.148	R$ 2.148	R$ 1.483	R$ 875	R$ 771
Urbanização	R$ 265	R$ 265	R$ 265	R$ 205	R$ 139	R$ 226
Drenagem	R$ 82	R$ 82	R$ 82	R$ 130	R$ 118	R$ 92
Extensão de Rede Elétrica	R$ 137	R$ 137	R$ 137	R$ 301	R$ 118	R$ 134
Extensão de Rede Hidráulica	R$ 1.663	R$ 1.663	R$ 1.663	R$ 847	R$ 500	R$ 319
CUSTO TOTAL III						
Incorridos						
CUSTO TOTAL IV	R$ 16.512		R$ 11.401			
Ed. Garagem	R$ 16.512		R$ 11.401			
CUSTO TOTAL V				R$ 285	R$ 553	R$ 535
Atualização por INCC				R$ 285	R$ 553	R$ 535
CUSTO TOTAL I+II	R$ 99.595	R$ 93.330	R$ 97.656	R$ 106.377	R$ 97.833	R$ 94.759
CUSTO TOTAL I AO IV	R$ 116.108	R$ 93.330	R$ 109.057	R$ 106.662	R$ 98.386	R$ 95.295

Custo de Construção

	BRUMATTI SANTOS CEN 01 | R00 - CONSOLIDADO	CUIABINHO CEN 02 | R01	
Torres	3	2	
Unidades Construídas	760 | 340	504	
Unidades Vendidas	754 | 338	499	
Total Unidades Vendidas	1092	499	
Condomínios (qta.)	1	1	
Cidade	Itaquaquecetuba - SP	Itaquaquecetuba - SP	
Produto / Selo	F2E - V0200 CDW	F2E - V0200 CDW	
Atributos	520 Varandas	-	
Tipologia	2 Torres | T+18 | 20PP	2 Torres | T+18 | 14PP	
Tipologia	1 Torres | T+16 | 20PP	-	
Projeto Infra	AP	AP	
Projeto Torre	AP	AP	
Mês Base	novembro-25	novembro-25	
Incc	1225,633	1222,356	
LVS	outubro-25	setembro-25	
Indiretos	outubro-25	setembro-25	
Base de Preço	LPU 97	LPU 96	
Takt	2x2	2x2	
Prazo (mês)	22 | 16	19	
CUSTO TOTAL I	R$ / UND R$ 95.508	R$ / UND R$ 104.893	DIF -R$ 9.385
Indireto	R$ 17.200	R$ 20.814	-R$ 3.613
Torre	R$ 57.201	R$ 56.573	**R$ 628**
Infra	R$ 14.119	R$ 18.204	-R$ 4.085
Fundação	R$ 5.291	R$ 6.699	-R$ 1.408
EEE	R$ 0	R$ 756	-R$ 756
ETE	R$ 0	R$ 0	R$ 0
Contenção	R$ 176	R$ 127	R$ 49
Terrapplenagem	R$ 1.520	R$ 1.721	-R$ 200
CUSTO TOTAL II	R$ 2.148	R$ 1.483	**R$ 665**
Urbanização	R$ 265	R$ 205	R$ 60
Drenagem	R$ 82	R$ 130	-R$ 48
Extensão de Rede Eletrica	R$ 137	R$ 301	-R$ 163
Extensão de Rede Hidráulica	R$ 1.663	R$ 847	**R$ 816**
CUSTO TOTAL III	R$ 0	R$ 0	R$ 0
Incorridos	R$ 0	R$ 0	R$ 0
CUSTO TOTAL IV	R$ 11.401	R$ 0	**R$ 11.401**
Ed. Garagem	R$ 11.401	R$ 0	**R$ 11.401**
CUSTO TOTAL V	R$ 0	R$ 285	-R$ 285
Atualização por INCC	R$ 0	R$ 285	-R$ 285
CUSTO TOTAL	R$ 109.057	R$ 106.662	**R$ 2.396**

INDIRETOS (Diluição)
-1.129 | Serviços Técnicos
-306 | Administração
-392 | Implantação de Canteiro
-624 | Equipamentos
-864 | Operação de Canteiro
-308 | Ensaios

TORRE
+120 | Aço (Projeto)
Cuiabinho: 52,50 kg/m³ | 6,62 R$/kg | 486 kg/U.H
Brumatti: 52,50 kg/m³ | 6,83 R$/kg | 537 kg/U.H
+255 | Concreto (Projeto)
Cuiabinho: 9,26 m³/U.H – 748 R$/m³
Brumatti: 10,22 m³/U.H – 748 R$/m³
+803 | Esquadrias de Alumínio (Projeto – Varandas + Caixilho Classe III)
+110 | Esquadrias de Ferro (Projeto/ Varandas)
-558 | Elevador (Projeto)
Cuiabinho: 4.321 R$/U.H - 8 elevadores
14PP T+17 – 2+2 elev/ torre | 1,0 m/s + 1,5 m/s
Brumatti: 3.763 R$/U.H (zoneado) – 14 elevadores
20PP – 3+2 Elev/ torre | 1m/s + 1,75 m/s
20PP – 2+2 Elev/ torre | 1m/s + 1,75 m/s

INFRA (Projeto/ Diluição)
+553 | Instalações (Solução de Drenagem + Extensão de Esgoto)
-449 | Alvenaria de Vedação
-1.794 | Outros Revest. De Piso
-216 | Esquadria de Ferro
-549 | Reserv. Metálico
Cuiabinho: 1 unid. – Ø3,80 – 23,94m
Brumatti: 3 unid. – Ø3,80 – 14,10m / 10,20m
-379 | Paisagismo
-953 | Outras Instalações
-233 | Enterrados

FUNDAÇÃO
-1.408 | Projeto / Diluição
Cuiabinho: Ø 40, 50 e 60cm - ~23m – 272 unid. 6.210m | 297 R$/m
Brumatti: Ø 60,70 e 80 cm – ~17m - 296 unid. – 5.131m | 500 R$/m

TERRAPLENAGEM
-200 | Projeto
Cuiabinho: Corte: 3.244 m³ | Aterro: 10.586 m³
Brumatti : Corte: 16.071 m³ | Aterro: 9.173 m³

Custo de Construção

	BRUMATTI SANTOS CEN 01 | R00 - CONSOLIDADO	PQ ANHANGUERA CONSOLIDADO | R11	
Torres	3	4	
Unidades Construídas	760 | 340	1292	
Unidades Vendidas	754 | 338	749 | 522	
Total Unidades Vendidas	1092	1271	
Condomínios (qta.)	1	1	
Cidade	Itaquaquecetuba - SP	São Paulo - SP	
Produto / Selo	F2E - V0200 CDW	F2E - V0200 CDW	
Atributos	520 Varandas	180 + 90 Varandas	
Tipologia	2 Torres | T+18 | 20PP	2 Torres | T+18 | 20PP	
Tipologia	1 Torres | T+16 | 20PP	1 Torre | T+18 | 18PP	
Tipologia	-	1 Torre | T+18 | 10PP	
Projeto Infra	AP	AP	
Projeto Torre	AP	AP	
Mês Base	novembro-25	outubro-25	
Incc	1225,633	1218,747	
LVS	outubro-25	agosto-25	
Indiretos	outubro-25	agosto-25	
Base de Preço	LPU 97	LPU 95	
Takt	2x2	2x2	
Prazo (mês)	22 | 16	25 | 20	
CUSTO TOTAL I	R$ / UND R$ 95.508	R$ / UND R$ 96.958	DIF -R$ 1.450
Indireto	R$ 17.200	R$ 18.734	-R$ 1.533
Torre	R$ 57.201	R$ 58.051	-R$ 850
Infra	R$ 14.119	R$ 13.255	**R$ 864**
Fundação	R$ 5.291	R$ 6.171	-R$ 880
EEE	R$ 0	R$ 0	R$ 0
ETE	R$ 0	R$ 0	R$ 0
Contenção	R$ 176	R$ 174	R$ 2
Terrapplenagem	R$ 1.520	R$ 572	**R$ 948**
CUSTO TOTAL II	R$ 2.148	R$ 875	**R$ 1.273**
Urbanização	R$ 265	R$ 139	R$ 127
Drenagem	R$ 82	R$ 118	-R$ 36
Extensão de Rede Eletrica	R$ 137	R$ 118	R$ 19
Extensão de Rede Hidráulica	R$ 1.663	R$ 500	**R$ 1.162**
CUSTO TOTAL III	R$ 0	R$ 0	R$ 0
Incorridos	R$ 0	R$ 0	R$ 0
CUSTO TOTAL IV	R$ 11.401	R$ 0	**R$ 11.401**
Ed. Garagem	R$ 11.401	R$ 0	**R$ 11.401**
CUSTO TOTAL V	R$ 0	R$ 553	-R$ 553
Atualização por INCC	R$ 0	R$ 553	-R$ 553
CUSTO TOTAL	R$ 109.057	R$ 98.386	**R$ 10.672**

INDIRETOS (Diluição)
-597 | Serviços Técnicos
-596 | Implantação de Canteiro
-212 | Operação de Canteiro
-115 | Ensaios

TORRE
-192 | MDO Vertical
+137 | Aço (Projeto)
Anhanguera: 52,50 kg/m³ | 6,62 R$/kg | 522 kg/U.H
Brumatti: 52,50 kg/m³ | 6,83 R$/kg | 537 kg/U.H
-719 | Gesso (Projeto/ Tipologia/ Diluição / Preço Parade de Drywwall)
+571 | Esquadrias de Alumínio (Projeto – Varandas + Caixilho Classe III)
+103 | Esquadrias de Ferro (Projeto/ Varandas)
-732 | Elevador (Projeto)
Anhanguera: 4.4495 R$/U.H (zoneado) – 17 elevadores
10PP – 3 Elev/ torre | 1,5m/s
18PP – 2+2 Elev/ torre | 1,5+2,5m/s
20PP – 3+2 Elev/ torre | 1m/s + 1,75 m/s
Brumatti: 3.763 R$/U.H (zoneado) – 14 elevadores
20PP – 3+2 Elev/ torre | 1m/s + 1,75 m/s
20PP – 2+2 Elev/ torre | 1m/s + 1,75 m/s

INFRA
+713 | Instalações (Solução de Drenagem + Extensão de Esgoto)
+626 | Outros Revest. Piso (Projeto – Piso Ed.Garagem)
+184 | Esquadrias de Ferro (Projeto)
-758 | Reserv. Metálico (Projeto)
Anhanguera: 5 unid. – Ø3,80 – 9,70m
Brumatti: 3 unid. – Ø3,80 – 14,10m / 10,20m
+161 | Paisagismo (Projeto)
-116 | Enterrados (Projeto)

FUNDAÇÃO
-880 | Projeto
Anhanguera: Φ 50,60 e 70 cm – ~19m - 673 unid. – 12.896m | 310 R$/m
Brumatti: Φ 60,70 e 80 cm – ~17m - 296 unid. – 5.131m | 500 R$/m

TERRAPLENAGEM
+948 | Projeto
Anhanguera.: Corte: 530 m³ | Aterro: 7.452 m³
Brumatti : Corte: 16.071 m³ | Aterro: 9.173 m³

Ed. Garagem

CUSTO TOTAL I	ED. GARAGEM T+4	
	R$ / A. CONSTRUIDA	R$ TOTAL
FUNDAÇÃO	R$ 174	R$ 1.464.662
ESTRUTURA	R$ 696	R$ 5.850.492
ALVENARIA	R$ 6	R$ 52.768
OUTROS REVEST. DE PISO	R$ 253	R$ 2.124.358
IMPERMEABILIZAÇÃO	R$ 172	R$ 1.442.457
SERRALHERIA	R$ 47	R$ 397.308
INSTALAÇÕES	R$ 58	R$ 485.459
PINTURA	R$ 5	R$ 42.252
LIMPEZA FINAL	R$ 15	R$ 126.090
ELEVADOR	R$ 55	R$ 464.385
CUSTO TOTAL	R$ 1.481	R$ 12.450.232

ÁREA CONSTRUÍDA:	8.406
R$ / A. CONSTRUÍDA:	1.481
NÚMERO DE VAGAS:	453
R$ / VAGA:	27.484

Operações

SISTEMA DE ABASTECIMENTO DE ÁGUA
Existe viabilidade técnica para abastecimento de água.
Considerado aproximadamente extensão de 350m.

SISTEMA DE ESGOTAMENTO SANITÁRIO
Existe viabilidade técnica para abastecimento de água.
Considerado aproximadamente extensão de 105m em MND.

SISTEMA DE DRENAGEM
Considerado Escada Hidráulica com descarte na rede pública.

SISTEMA DE ABASTECIMENTO DE GÁS
Abastecimento por GLP.

SISTEMA DE ABASTECIMENTO ELÉTRICO
Não há viabilidade.

TERRENO

URBANIZAÇÃO
Considerado trecho de reconstituição do calçada na testada do terreno.

Operações

Matriz Risco Concessionária	
Água	Nível 3
Esgoto	Nível 3
Drenagem	NA
Elétrica	Nível 3
Gás	NA
Urbanização	NA

LEGENDA		
Nível	Tipo	Status
1	Com Diretriz	Conclusiva
2		Conclusiva com projeto aprovado
3		Conclusiva sem projeto aprovado
4		Não Conclusiva
5	Sem Diretriz	-
NA	-	Não aplicável

Água:
- Viabilidade emitida em 09/2024, com validade em 09/2026.

Esgoto:
- Viabilidade emitida em 09/2024, com validade em 09/2026.

Drenagem:
- Não se aplica.

Elétrica:
- No pedido de ligação definitiva a concessionária pode vir a cobrar reformas necessárias, caso a infraestrutura existente não seja suficiente.

Gás:
- Empreendimento com GLP.

Urbanização:
- Considerado trecho de reconstituição do calçada na testada do terreno.

Fundação:
- Realizada campanha de sondagem contemplando 08 furos. Necessário sondagem complementar.
- Considerada Estaca Hélice, com diâmetros de 60,70 e 80cm e profundidade de 17 e 18 m.

Logística

FASE 01

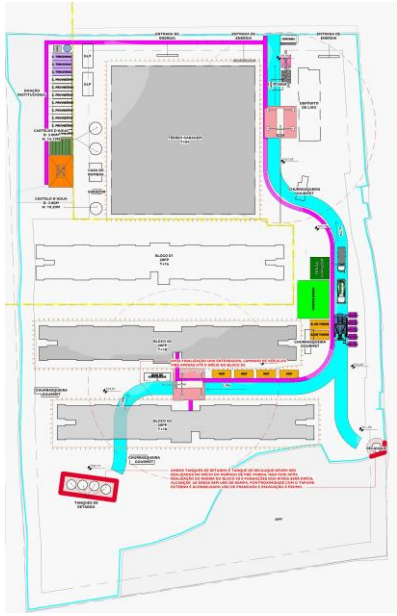

FASE 02

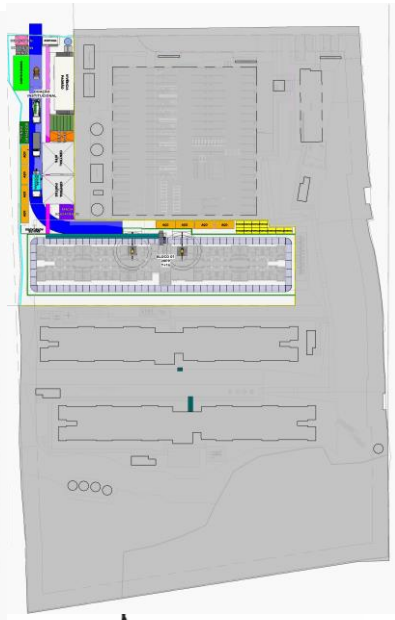

VIVÊNCIA - CONTAINERS								
DESCRIÇÃO	QUANTIDADE	TAMANHO MÓDULOS	MOBILIZAÇÃO	DESMOBILIZAÇÃO	PRÉ FORMA	ESTRUTURA	ACAB.	FASE
CONTAINER PORTARIA (LOG)	CONSIDERAR 1 MÓDULO DE CONTAINER	2,41m X 4,90m	1 MOB	1 DESMOB	TODO PERÍODO	TODO PERÍODO	TODO PERÍODO	FASE 01 E 02
CONTAINER PROVISÓRIO (LOG)	CONSIDERAR 8 MÓDULOS DE CONTAINER	2,41 X 6,10 m	1 MOB	1 DESMOB	TODO PERÍODO	-	-	FASE 01 E 02
CONTAINER VIVÊNCIA PADRÃO (LOG)	7 MÓDULOS DE CONTAINER EMBAIXO, 7 MÓDULOS EM CIMA	2,41 X 6,10 m	1 MOB	1 DESMOB	-	TODO PERÍODO	TODO PERÍODO	FASE 01 E 02

FASE 01 E 02

LOG_LAZER							
DESCRIÇÃO	QUANTIDADE	MOBILIZAÇÃO	DESMOBILIZAÇÃO	PRÉ FORMA	ESTRUTURA	ACABAMENTO	FASE
FUMODROMO PEQUENO (LOG)	4	-	-	TODO PERÍODO	TODO PERÍODO	TODO PERÍODO	FASE 01 E FASE 02
TENDA LAZER	4	-	-	-	TODO PERÍODO	TODO PERÍODO	FASE 01 E FASE 02

FASE 01 E FASE 02

TENDAS_PERÍODOS							
DESCRIÇÃO	QUANTIDADE	LARGURA	COMPRIMIENTO	PRÉ FORMA	ESTRUTURA	ACABAMENTO	FASE
GAIOLA DE DESMOLDANTE (LOG)	1	4,00	6,00	-	TODO PERÍODO		FASE 01
GAIOLA DE INFLAMÁVEIS (LOG)	2	3,00	4,00	-	TODO PERÍODO	TODO PERÍODO	FASE 01
TENDA ACABAMENTO (LOG)	1	5,00	8,00	-	TODO PERÍODO	TODO PERÍODO	FASE 01
TENDA ARMADOR (LOG)	1	4,00	7,00	TODO PERÍODO	TODO PERÍODO	-	FASE 01
TENDA ARMADOR (LOG)	4	6,00	7,00	TODO PERÍODO	TODO PERÍODO	-	FASE 01
TENDA CENTRAL DE HITS (LOG)	1	10,00	10,00	-	TODO PERÍODO	TODO PERÍODO	FASE 01
TENDA CENTRAL DE PORTAS (LOG)	1	10,00	9,00	-	TODO PERÍODO	TODO PERÍODO	FASE 01
TENDA MOLDADOR (LOG)	2	3,00	4,00	TODO PERÍODO	TODO PERÍODO	-	FASE 01
FASE 01							
GAIOLA DE INFLAMÁVEIS (LOG)	2	3,00	4,00	-	TODO PERÍODO	TODO PERÍODO	FASE 02
TENDA ACABAMENTO (LOG)	1	5,00	4,80	-	TODO PERÍODO	TODO PERÍODO	FASE 02
TENDA ARMADOR (LOG)	1	3,00	7,00	TODO PERÍODO	TODO PERÍODO	-	FASE 02
TENDA ARMADOR (LOG)	1	4,00	9,00	TODO PERÍODO	TODO PERÍODO	-	FASE 02
TENDA CENTRAL DE HITS (LOG)	1	10,00	10,00	-	TODO PERÍODO	TODO PERÍODO	FASE 02
TENDA CENTRAL DE PORTAS (LOG)	1	10,00	9,00	-	TODO PERÍODO	TODO PERÍODO	FASE 02
TENDA MOLDADOR (LOG)	2	3,00	4,00	TODO PERÍODO	TODO PERÍODO	-	FASE 02

FASE 02

LOG_EQUIPAMENTOS E MAQUINÁRIOS							
EQUIPAMENTO	QUANTIDADE	MOBILIZAÇÃO	DESMOBILIZAÇÃO	PRÉ FORMA	ESTRUTURA	ACABAMENTO	FASE
BETONEIRA (LOG)	1 EQUIPAMENTO	-	-	TODO PERÍODO	TODO PERÍODO	-	FASE 01 E FASE 02
BOBCAT (LOG)	1 EQUIPAMENTO	1 MOBILIZAÇÃO	1 DESMOBILIZAÇÃO	-	TODO PERÍODO	CONSIDERAR 15 DIAS DO PERÍODO DE ACABAMENTO	FASE 01 E FASE 02
BOMBA ESTACIONÁRIA PADRÃO (LOG)	1 EQUIPAMENTO	-	-	-	TODO PERÍODO	-	FASE 01 E FASE 02
BOMBA LANÇA (LOG)	1 EQUIPAMENTO	-	-	TODO PERÍODO	TODO PERÍODO	-	FASE 01 E FASE 02
CAMINHÃO MUNCK (LOG)	1 EQUIPAMENTO	1 MOBILIZAÇÃO	1 DESMOBILIZAÇÃO	-	CONSIDERAR MEIO PERÍODO DE ESTRUTURA	-	FASE 01 E FASE 02
CREMALHEIRA CDW (LOG)	2 EQUIPAMENTOS	1 MOB DE CREMALHEIRA POR TORRE (TAKT 2X2)	1 DESMOB DE CREMALHEIRA POR TORRE (TAKT 2X2)	-	TODO PERÍODO	TODO PERÍODO	FASE 01 E FASE 02
MINIGRUA (LOG)	2 EQUIPAMENTOS.	1 MOB POR MINIGRUA POR TORRE (TAKT 2X2)	1 DESMOB POR MINIGRUA POR TORRE (TAKT 2X2)	-	TODO PERÍODO	-	FASE 01 E FASE 02
PERFURATRIZ (LOG)		1 MOBILIZAÇÃO	1 DESMOBILIZAÇÃO	CONSIDERAR PERÍODO DE ESTACA CONFORME PROJETO.	-	-	FASE 01 E FASE 02

FASE 01 E FASE 02

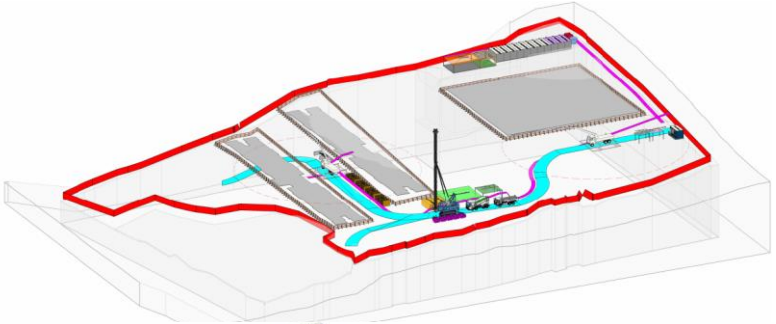

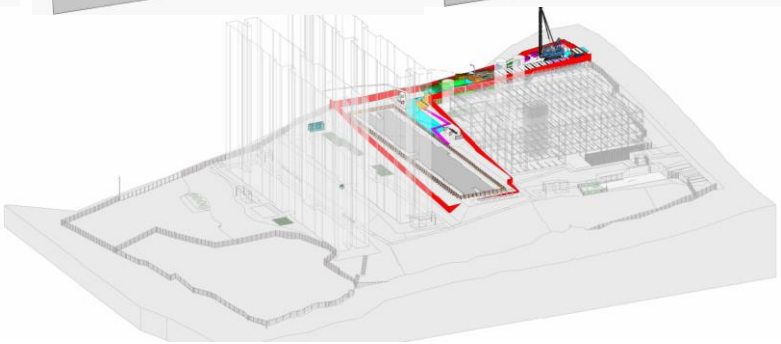

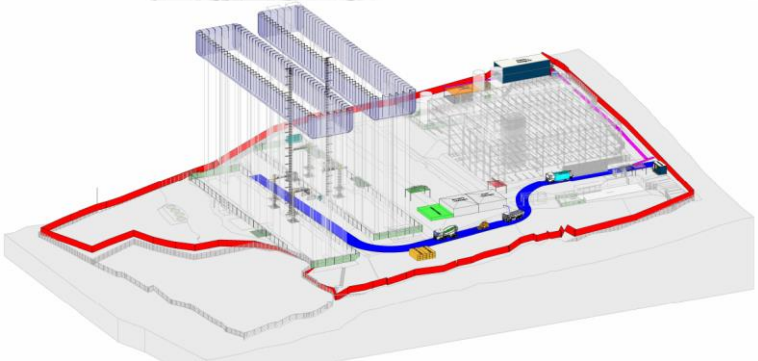

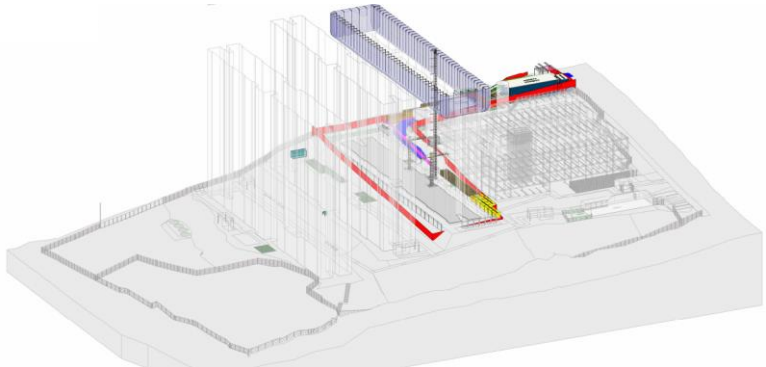

Pareceres

Análise da Mancha e Implantação

Prospecção

Operações

Inteligência de Mercado

Financeiro

Anexos

Demanda e Distribuição da Mancha

Potencial de Demanda			Lançados		Lanç + Landbank	
Mancha	CÓD.	Shr.	ANO	MÊS	ANO	MÊS
Guarulhos	GRU	30%	1.762	147	2.114	176

Faixas MCMV	Empreendimento	Renda	Lançamento	jun/27	jul/27	ago/27	set/27	out/27	nov/27	dez/27	jan/28	fev/28	mar/28	abr/28	mai/28	jun/28	jul/28	ago/28	set/28	out/28	nov/28	dez/28	jan/29	fev/29	mar/29
Faixa 2	**Brumatti F1**	**3.844**	**jun-27**		**41**	**41**	**41**	**41**	**41**	**41**	**41**	**41**	**41**	**41**	**41**	**41**	**41**	**41**	**41**	**41**	**41**	**41**	**16**		
Faixa 2	**Brumatti F2**	**3.844**	**out-28**																		**14**	**14**	**14**	**14**	**14**
Total de Vendas Lançados				**0**	**0**	**0**	**0**	**0**	**0**	**0**	**0**	**0**	**0**	**0**	**0**	**0**	**0**	**0**	**0**	**0**	**0**	**0**	**0**	**0**	**0**
Total de Vendas Lançados + Landbank				**0**	**41**	**41**	**41**	**41**	**41**	**41**	**41**	**41**	**41**	**41**	**41**	**41**	**41**	**41**	**41**	**41**	**55**	**55**	**30**	**14**	**14**
Total Mancha | Faixa 1					*0%*	*0%*	*0%*	*0%*	*0%*	*0%*	*0%*	*0%*	*0%*	*0%*	*0%*	*0%*	*0%*	*0%*	*0%*	*0%*	*0%*	*0%*	*0%*	*0%*	*0%*
Total Mancha | Faixa 2					*100%*	*100%*	*100%*	*100%*	*100%*	*100%*	*100%*	*100%*	*100%*	*100%*	*100%*	*100%*	*100%*	*100%*	*100%*	*100%*	*100%*	*100%*	*100%*	*100%*	*100%*
Total Mancha | Faixa 3					*0%*	*0%*	*0%*	*0%*	*0%*	*0%*	*0%*	*0%*	*0%*	*0%*	*0%*	*0%*	*0%*	*0%*	*0%*	*0%*	*0%*	*0%*	*0%*	*0%*	*0%*

Parecer de I.M sobre a mancha:

O projeto analisado em comitê está em linha com o potencial teórico de demanda calculado para a mancha. (Total Lanç + Landbank)

Canibalização:

Sem Risco de Canibalização

Brumatti F1 | Mapa Concorrência

		Brumatti F1	Monet Fase 1	Sol Bonsucesso
		TENDA	Souza Araujo	Sol
	Distância Tenda (km)		3km	4,6km
Região 1 Km	População	21.235	18.034	31.194
	Dens. Demográfica	6.803	5.777	9.994
	Renda (R$)	3.931	3.862	4.063
	Classe Social	C1 (2.7k a 4.6k)	C2 (1.5k a 2.7k)	C1 (2.7k a 4.6k)
	PEA Dia	8.775	14.397	17.695
Quantitativo	Lançamento	set/27	07/2024	09/2024
	Unidades	754	264	400
	Estoque	754	35	6
	VSO	41	14	28
	Stockout	18	2	0
Qualitativo	Condomínios	1	1	1
	Torres	3	3	3
	Gabarito	T+18	T+11	T+14
	Plantas (m²)	31,86m²	46,49m²	34,24m² e 37,17m²
	Tipologia	2 Dorms	2 Dorms	2 Dorms
	Opções	Não	Não	Não
	Varanda	Sim	Sim	Sim
	Vagas	37%	Com Vaga	0,91
	Lazer	Salão De Festa Com Churrasqueira, Salão De Festa Interno, Espaço Office, Brinquedoteca, Espaço Saúde, Fitness Interno, Churrasqueira Gourmet, Quadra, Piscina, Play Kids, Play Baby, Pet Place, Fitness, Praça De Chegada, Espaço Convívio.	Tem Sacada, Academia ao ar livre, Bicicletário, Pet Place, Piscina, Piscina infantil, Playground, Quiosque, Sacada, Salão de Festas,	Tem Sacada, Academia ao ar livre, Bicicletário, Bosque, Churrasqueria, Fitness Center, Piscina, Playground, Quadra de Tênis, Sacada, Sauna Seca,

Farol Renda
Acima de 300
Entre 0 e 300
Abaixo de 0

Diagnóstico Concorrência

- A concorrência possui target de preço e renda superior ao previsto para o produto Tenda.

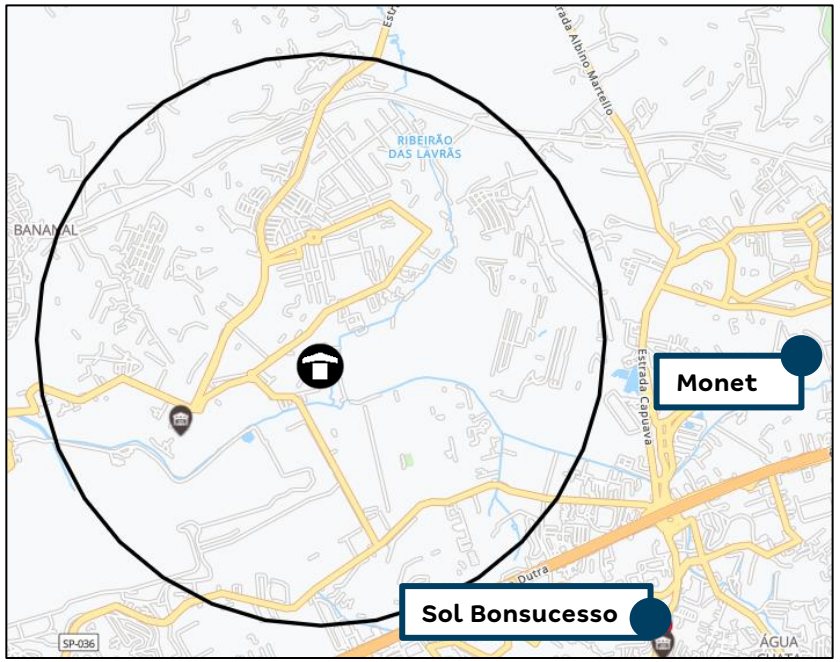

-	Brumatti F1					Monet Fase 1					Sol Bonsucesso				
Tipologias	Avaliação	Preço Nominal	CEF	Renda	% Unidades	Preço Nominal	CEF	Renda	Dif	Farol	Preço Nominal	CEF	Renda	Dif	Farol
HIS 1	237.000	227.146	181.551	3.094	53%	-	-	-	-		258.815	207.052	4.650	1.556	●
HIS 2 c/ Varanda	255.000	243.065	194.319	3.743	5%	257.825	206.260	4.600	857	●	279.562	223.650	5.600	1.857	●
HIS 2 Vg Moto Varanda	265.000	247.556	197.909	3.898	5%	-	-	-	-		-	-	-	-	
HIS 1 Vg Carro Desc Varanda	270.000	252.089	197.944	3.981	8%	-	-	-	-		295.453	236.362	5.900	1.919	●
HIS 2 Vg Carro Desc Varanda	270.000	263.422	207.589	4.693	5%	-	-	-	-		-	-	-	-	
HIS 2 Vg Carro Cober Varanda	285.000	271.760	215.244	5.247	25%	-	-	-	-		-	-	-	-	

Simulação de Preço

Informações Viabilidade

Projeto:	Brumatti F1					
Tipo:	**HIS 1**		**HIS 2 c/ Varanda**		**HIS 2 Vg Moto Varanda**	
Método	**Vision**		**Vision**		**Vision**	
Avaliação	237.000		255.000		265.000	
Renda Inicial (VF)	3.094		3.743		3.898	
Renda Final*	-		-		-	
% RET1	50%		0%		0%	
Tipo:	**VF**	**R$**	**VF**	**R$**	**VF**	**R$**
Ato	0,33	1.035	0,48	1.830	0,52	2.046
FGTS	0,49	1.549	0,48	1.825	0,48	1.912
Financiamento	98,42%	170.395	97,82%	188.899	97,58%	192.433
Subsídio	132,84%	9.608	158,48%	3.595	163,27%	3.565
Prazo de Pró-soluto	27	27	27	27	27	27
Pró-Soluto	86,30%	26.194	73,65%	27.044	71,73%	27.427
Preço Raso (RS)	208.781	208.781	223.193	223.193	227.383	227.383
TCD	58,89%	18.365	52,67%	19.872	51,34%	20.174
VSO	22	22	2	2	2	2
Preço de Venda	**223.830**	**223.830**	**239.516**	**239.516**	**243.942**	**243.942**
Elasticidade	1,481%	1,481%	1,481%	1,481%	1,481%	1,481%
Preço de Venda Final	**227.146**	**227.146**	**243.065**	**243.065**	**247.556**	**247.556**
Preço Raso (R$)	**208.781**		**223.193**		**227.383**	
% de Raso	**91,91%**		**91,82%**		**91,85%**	
BP25 - Não Inflacionado	-		-		-	
BP25 - Inflacionado	-		-		-	

Simulação de Preço

Informações Viabilidade

Projeto:	Brumatti F1					
Tipo:	**HIS 1 Vg Carro Desc Varanda**		**HIS 2 Vg Carro Desc Varanda**		**HIS 2 Vg Carro Cober Varanda**	
Método	**Vision**		**Vision**		**Vision**	
Avaliação	270.000		270.000		285.000	
Renda Inicial (VF)	3.981		4.693		5.247	
Renda Final*	-		-		-	
% RET1	0%		0%		0%	
Tipo:	**VF**	**R$**	**VF**	**R$**	**VF**	**R$**
Ato	0,54	2.193	0,57	2.694	0,55	2.925
FGTS	0,55	2.221	0,61	2.889	0,61	3.244
Financiamento	96,28%	192.174	98,25%	204.700	97,87%	211.999
Subsídio	162,50%	3.549	0,00%	0	0,00%	0
Prazo de Pró-soluto	27	27	27	27	27	27
Pró-Soluto	80,68%	31.510	68,74%	31.647	61,96%	31.894
Preço Raso (RS)	231.647	231.647	241.930	241.930	250.062	250.062
TCD	50,94%	20.441	45,43%	21.492	41,02%	21.698
VSO	3	3	2	2	10	10
Preço de Venda	**248.409**	**248.409**	**259.576**	**259.576**	**267.792**	**267.792**
Elasticidade	1,481%	1,481%	1,481%	1,481%	1,481%	1,481%
Preço de Venda Final	**252.089**	**252.089**	**263.422**	**263.422**	**271.760**	**271.760**
Preço Raso (R$)	**231.647**		**241.930**		**250.062**	
% de Raso	**91,89%**		**91,84%**		**92,02%**	
BP25 - Não Inflacionado	**-**		**0**		**0**	
BP25 - Inflacionado	**-**		**0**		**0**	

Análise de Preço

Informações Viabilidade

Projeto:	Brumatti F1
Tipo:	**Faixa 2**
Método	**Vision**
Avaliação	255.357
Renda Inicial (VF)	3.844
Renda Final*	-

Tipo:	VF	R$
Ato	0,43	1.762
FGTS	0,53	2.115
Financiamento	98,03%	186.041
Subsídio	99,11%	5.702
Prazo de Pró-soluto	27	27
Pró-Soluto	77,66%	28.383
Preço Raso (RS)	224.003	224.003
TCD	52,52%	19.666
VSO	41	41
Preço de Venda	**240.059**	**240.059**
Elasticidade	1,481%	1,481%
Preço de Venda Final	**243.669**	**243.669**

Preço Raso (R$)	**224.003**
% de Raso	**91,93%**
Raso Todas as Fases	**226.264**
Nominal Todas as Fases	**246.303**

1

Análise de Riscos

Farol IM

IM avalia o Preço Vision como **factível**.

1) Entendemos ser possível capturar os preços e rendas estimados no parecer, considerando que o Jardim dos Prados, atual referência da mancha, apresenta localização e produto inferiores, ainda assim alcançando renda mediana de aproximadamente R$ 3,4 mil, apenas R$ 400 abaixo da estimada pelo Vision.

A diferença de produto decorre, principalmente, da presença de atributos como piscina, varanda e edifício garagem.

Além disso, conforme consta no slide "Panorama de Concorrência", os concorrentes da região vendem em um target de preço e renda acima do previsto para o Produto Tenda.

	Preço Real					Preço Normalizado (27m)	
	Avaliação	Preço Raso	Renda Mediana	VSO	PSOL	Δ PSOL	Preço Raso
Jd. Dos Prados	234.914	209.351	3.460	55	30	-2.853	206.498
Brumatti F1	255.357	224.003	3.844	41	27	-	224.003

Resumo de Preços

Vision

Nome Fase	Tipologia	Renda	Ato	FGTS	Cond.	Subsídio	PSOL	TCD	VSO	Nom. Pré	Avali.	Elast.	Nom. Pós	Raso Pós	PSOL (m)	RET1
Brumatti F2	HIS 1	3.094	0,33	0,49	99,3%	132,8%	93,2%	63,6%	10	218.094	237.000	9,6296%	239.096	219.256	21	50%
Brumatti F2	HIS 1 c/ Varanda	3.594	0,45	0,45	99,7%	145,3%	82,4%	56,7%	3	228.941	255.000	9,6296%	250.987	230.440	21	25%
Brumatti F2	HIS 2 Vg Moto Varanda	3.898	0,52	0,48	99,6%	163,3%	77,5%	55,5%	1	237.936	265.000	9,6296%	260.849	239.055	21	0%
Brumatti F2	S 2 Vg Carro Cober Varar	5.177	0,52	0,58	101,2%	0,0%	60,6%	44,3%	5	254.607	285.000	9,6296%	279.125	256.014	21	0%
																0%
																0%
																0%
																0%
																0%
																0%
																0%
																0%
																0%
																0%

Ciclo Financeiro – Análise Mancha

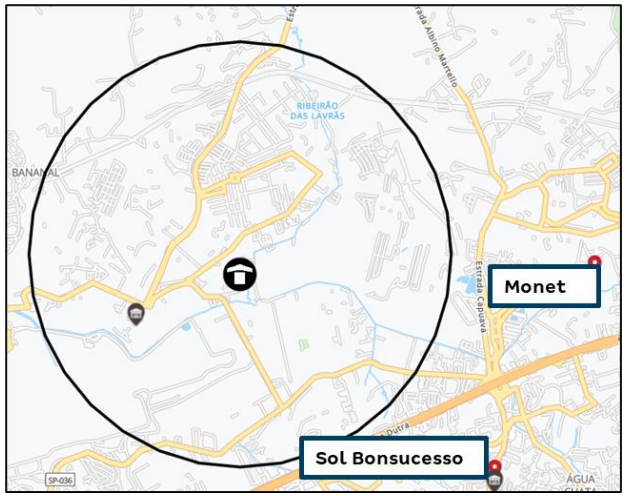

-	Brumatti - F1					Monet Fase 1					Sol Bonsucesso				
Tipologias	Avaliação	Preço Nominal	CEF	Renda	% Unidades	Preço Nominal	CEF	Renda	% Unidades	Farol	Preço Nominal	CEF	Renda	% Unidades	Farol
Sem Vaga	260.000	226.250	181.869	3.197	64%	-	-	-	-	-	258.815	207.052	4.650	11%	●
Varanda	270.000	243.493	192.127	3.583	13%	257.825	206.260	4.600	100%	●	279.562	223.650	5.600	45%	●
Moto + Varanda	280.000	250.245	196.015	3.800	9%	-	-	-	-	-	-	-	-	-	-
Carro + Varanda	290.000	259.926	200.718	4.291	19%	-	-	-	-	-	295.453	236.362	5.900	45%	●
Carro Coberto + Varanda	300.000	265.561	205.698	4.581	24%	-	-	-	-	-	-	-	-	-	-

Parecer Ciclo

O Ciclo validou o preço e VSO como viáveis. O projeto está estrategicamente localizado na região de Guarulhos região melhor que a região do Prados (Bonsucesso). A área apresenta forte potencial de demanda e, mesmo diante da presença de concorrentes, estamos com preços competitivos. Além disso, já observamos ganhos de aprox. 25mil nas vagas descobertas do Prados, corroborando para oportunidade de ganhos futuros frente ao Book no Brumatti.

Pareceres

Análise da Mancha e Implantação

Prospecção

Operações

Inteligência de Mercado

Financeiro

Anexos

Informações Financeiras

BRUMATTI SANTOS - SPRM - Região Metropolitana > 100mil SP

Datas e Prazos

	Compra	Lançamento	Início Obra	Término Obra	LÇTO até IO	IO até TO	Chaves	LÇTO até Chaves
Consolidado	set-25							
F1 sem vaga HIS1		jun-27	dez-27	out-29	6 meses	22 meses	jun-30	36 meses
F1 sem vaga c varanda HIS2		jun-27	dez-27	out-29	6 meses	22 meses	jun-30	36 meses
F1 moto c varanda HIS2		jun-27	dez-27	out-29	6 meses	22 meses	jun-30	36 meses
F1 carro descob c varanda HIS1		jun-27	dez-27	out-29	6 meses	22 meses	jun-30	36 meses
F1 carro descob c varanda HIS2		jun-27	dez-27	out-29	6 meses	22 meses	jun-30	36 meses
F1 carro cob c varanda HIS2		jun-27	dez-27	out-29	6 meses	22 meses	jun-30	36 meses
F2 sem vaga HIS1		out-28	abr-29	ago-30	6 meses	16 meses	out-31	36 meses
F2 sem vaga c varanda HIS2		out-28	abr-29	ago-30	6 meses	16 meses	out-31	36 meses
F1 moto c varanda HIS2		out-28	abr-29	ago-30	6 meses	16 meses	out-31	36 meses
F2 carro cob c varanda HIS2		out-28	abr-29	ago-30	6 meses	16 meses	out-31	36 meses

Terreno e Incorridos

TOTAL (R$ + Perm.):	17,37 MM	**Incorrido Terreno:**	0,00 MM	**Área do Terreno (100%):**	19.634 m²	**Área Líquida do Terreno:**	16.338 m²
Cash:	3,93 MM	**Nº de Parcelas Cash :**	4	**Custo de terreno m²:**	884,9	**Custo de terreno m² Área Líquida:**	1.063,5
Permuta Financeira:	13,45 MM (5,00%)			**VaR 25 (R$ mil):**	0	**Fração Terreno/Terreno + Custo Obra (%VGV):**	6,5% / 50,7%
Permuta Física:	0,00 MM (0,00%)			**VaR 26 (R$ mil):**	0	**CA Máx/Proj.**	3,5 / 1,9
Ato / %VGV:	0,98 MM / 0,4%			**Incorrido de Construção:**	0,00 MM	**Incorridos de Incorporação:**	0,07 MM

Vendas

Fases	Nº Pavimentos	Preço Raso Unit.	Qtde	Preço Unit.	Aval. CEF	Cond. Parcela	% Pró-soluto	% TCD
F1 sem vaga HIS1	T+18	208.781	397	227.146	237.000	98,4%	86,3%	58,9%
F1 sem vaga c varanda HIS2	T+18	223.193	35	243.065	255.000	97,8%	73,7%	52,7%
F1 moto c varanda HIS2	T+18	227.383	41	247.556	265.000	97,6%	71,7%	51,3%
F1 carro descob c varanda HIS1	T+18	231.647	60	252.089	270.000	96,3%	80,7%	50,9%
F1 carro descob c varanda HIS2	T+18	241.930	35	263.422	270.000	98,3%	68,7%	45,4%
F1 carro cob c varanda HIS2	T+18	250.062	186	271.760	285.000	97,9%	62,0%	41,0%
F2 sem vaga HIS1	T+18	219.256	179	239.096	237.000	99,3%	93,2%	63,6%
F2 sem vaga c varanda HIS2	T+18	230.440	58	250.987	255.000	99,7%	82,4%	56,7%
F1 moto c varanda HIS2	T+18	239.055	17	260.849	265.000	99,6%	77,5%	55,5%
F2 carro cob c varanda HIS2	T+18	256.014	84	279.125	285.000	101,2%	60,6%	44,3%

Unidades Totais:	1.092	**Preço Médio:**	246.303	**Renda Média:**	3.811	**ITBI+Emol. Unit. Médio:**	4.260
Unidades Tenda:	1.092	**Avaliação Média:**	254.759	**Ato:**	1.609 (0,42 Salários)	**Custo do Ciclo Unit.:**	15.516
VSO:	30 Unidades	**VGV Total:**	268.962.696	**FGTS:**	1.994 (0,52 Salários)	**Preço Raso Médio:**	226.264
RET Médio:	3,2%	**VGV Tenda:**	268.962.696	**% em RET 1%:**	28%	**Adc. Tx. de Aceleração Médio:**	750

Construção

Custo Total Unit. | Corrigido:	109.057 | 108.765	**Eventuais:**	4,00%	**Área priv (m²):**	31,86	**Gape / Mês Unit.:**	11,08

Resultado

LI (R$):	**30.610.652**	**LI:**	**20,00%**	**Exposição de Caixa (R$):**	**25.678.482**	**Margem Bruta Econômica:**	**38,63%**
TIR:	**105,39%**	**LI Aprovação:**	**20,00%**	**Ger. Caixa 12 meses (R$):**	**0**	**Margem Bruta REF:**	**42,13%**
Exposição de Caixa:	**8,79%**	**Δ LI:**	**0,00%**	**Ger. Caixa 24 meses (R$):**	**(11.570.928)**	**Margem Rasa Econômica:**	**32,52%**
Payback Contingente (21 m):	**21 m/ (0 m)**	**LI Resiliência:**	**12,68%**	**Ger. Caixa Marginal (R$):**	**74.390.013**	**Margem Rasa REF:**	**37,01%**
Payback Consolidado:	**21 meses**					**Margem de Contribuição Econômica:**	**27,38%**

DRE

R$ Mil - Valores Nominais - Compra	BRUMATTI SANTOS		Primeira Fase		Demais Fases	
	Nominal	%	Nominal	%	Nominal	%
Receita	291.986	100,0%	195.358	100,0%	96.628	100,0%
PIS/COFINS	(5.149)	1,8%	(3.496)	1,8%	(1.653)	1,7%
Custo Total	(176.046)	61,4%	(126.264)	65,8%	(49.782)	52,4%
Custo Terreno	(22.113)	7,7%	(14.984)	7,8%	(7.129)	7,5%
Custo Relacionados a Terreno	(2.031)	0,7%	(1.384)	0,7%	(647)	0,7%
Custos de Incorporação	(6.683)	2,3%	(4.585)	2,4%	(2.099)	2,2%
Custo de Construção	(145.218)	50,6%	(105.312)	54,9%	(39.907)	42,0%
Lucro Bruto Econômico	110.791	38,6%	65.598	34,2%	45.194	47,6%
Custo para Rateio	-	0,0%	-	0,0%	-	0,0%
Lucro Bruto Contábil	110.791	38,6%	65.598	34,2%	45.194	47,6%
Despesas de Selling	(25.539)	8,9%	(17.087)	8,9%	(8.452)	8,9%
Contingência	(6.716)	2,3%	(4.493)	2,3%	(2.222)	2,3%
Margem de Contribuição	78.537	27,4%	44.018	22,9%	34.519	36,3%
IR e CSLL	(4.213)	1,4%	(2.860)	1,5%	(1.353)	1,4%
Margem Líquida	74.324	25,9%	41.158	21,5%	33.166	34,9%
Lucro Bruto REF Unit.	116.195	42,1%	101.396	37,9%		
Lucro Raso REF Unit.	93.778	37,0%	79.860	32,5%		

R$ Mil - VPL - Compra	BRUMATTI SANTOS		Primeira Fase		Demais Fases	
	VP	%	VP	%	VP	%
Receitas	153.071	100,0%	108.714	100,0%	44.357	100,0%
PIS/COFINS	(2.663)	1,7%	(1.915)	1,8%	(748)	1,7%
Custos e Despesas Totais	(119.797)	78,3%	(89.176)	82,0%	(30.621)	69,0%
Custo Terreno	(11.565)	7,6%	(8.183)	7,5%	(3.382)	7,6%
Custo Relacionados a Terreno	(1.501)	1,0%	(1.023)	0,9%	(479)	1,1%
Custos de Incorporação	(3.866)	2,5%	(2.718)	2,5%	(1.148)	2,6%
Custo de Construção	(82.945)	54,2%	(62.987)	57,9%	(19.958)	45,0%
Despesas de Selling	(15.890)	10,4%	(11.402)	10,5%	(4.488)	10,1%
Contingência	(1.852)	1,2%	(1.297)	1,2%	(555)	1,3%
IR e CSLL	(2.178)	1,4%	(1.567)	1,4%	(612)	1,4%
Lucro Imobiliário	30.611	20,0%	17.623	16,2%	12.988	29,3%

Comparativo (Comitê Essencial x Comitê Ampliado)

Comparativo dos Estudos - Consolidado	Anterior	Atual	Atual vs Anterior	Δ%
Data Estudo:	setembro-25	dezembro-25	3 Meses	N/A
Lançamento:	julho-27	junho-27	-1 Meses	N/A
Uhs:	1.092	1.092	-	0,0%
Preço Nominal:	246.884	246.303	(582)	-0,2%
Preço Raso:	225.723	226.264	540	0,2%
Preço Nominal Inflacionado:	283.002	275.799	(7.202)	-2,5%
Preço Raso Inflacionado:	258.771	253.383	(5.388)	-2,1%
Renda Média:	3.717	3.811	94	2,5%
RET Médio:	3,33%	3,17%	-0,2 p.p.	-5,0%
% em RET 1%:	22,18%	27,70%	5,5 p.p.	24,9%
VSO:	31	30	(1)	-1,6%
ITBI/Emol. Inf (Unit)[2]:	5.658	5.506	(152)	-2,7%
Avaliação:	254.177	254.759	582	0,2%
Prazo construção F1:	22	22	-	0,0%
Prazo de Pró-Soluto F1:	27	27	-	0,0%
Custo Total Inf (Unit):	163.458	161.214	(2.244)	-1,4%
Custo Construção (Unit):	109.301	109.057	(244)	-0,2%
Fração de construção:	44%	44,2%	0,1 p.p.	0,3%
INCC Folha Rosto:	1.216,71	1.225,63	9	0,7%
Custo Terreno Inf:	22.164.499	22.113.134	(51.364)	-0,2%
Custo Relacionados a Terreno (Unit):	1.771	1.860	90	5,1%
Fração do Terreno[1]:	6,5% / 50,7%	6,5% / 50,7%	0,0 p.p.	0,0%
Custo de Incorp. por uh:	4.801	6.120	1.320	27,5%
ITBI/Emol. Inf (Total)[2]:	6.178.125	6.012.087	(166.038)	-2,7%
Custo do Ciclo (Unit):	15.544	15.516	(29)	-0,2%
LI Resiliência:	7,8%	12,7%	4,9 p.p.	62,3%
Lucro Imobiliário:	20,5%	20,0%	-0,5 p.p.	-2,4%
LI Resiliência:	7,8%	12,7%	4,9 p.p.	62,3%
Exposição de caixa:	8,2%	8,8%	0,5 p.p.	6,7%
TIR:	108,2%	105,4%	-2,9 p.p.	-2,6%
Margem Bruta REF:	42,8%	42,1%	-0,7 p.p.	-1,6%
Margem Bruta Econômica:	39,3%	38,6%	-0,7 p.p.	-1,8%
Margem Rasa REF:	37,5%	37,0%	-0,4 p.p.	-1,2%
Margem Rasa Econômica:	32,9%	32,5%	-0,4 p.p.	-1,2%
Margem Contribuição Econômica:	28,1%	27,4%	-0,7 p.p.	-2,5%
Payback Contingente (Régua 21 m):	20 m/ (-1 m)	21 m/ (0 m)	1	
Payback Consolidado:	21 Meses	21 Meses	0 Meses	0,0%

[1] Valor do terreno contratual

[2] ITBI com taxa de Aceleração

Pareceres

Análise da Mancha e Implantação

Prospecção

Operações

Inteligência de Mercado

Financeiro

Anexos

LEGALIZAÇÃO E DPP

- **ÁREA DE IMPLANTAÇÃO**

- O terreno é composto por 1 matrícula 178.383 (2 CRI), em nome de pessoa física, e totaliza uma área de 19.633,64m² (TERRENO).
- Área real de 19.372,73 m²;
- O cadastro do imóvel é urbano.

- **DIRETRIZES URBANÍSTICAS para 820uh HIS1**

- O terreno esta inserido em ZUD 4, conforme leis 7888/21 e 8213/23:
  - C.A. máximo: 3,5 para HIS 1 e TO 70%.
- **Regularização Ambiental:**
  - Analisado sobre o processo administrativo 31.762/2017, deferido para cancelamento do auto de infração.
- **Reserva de Área Pública:**
  - Projeto atual considera doação de área de 5% da área total do terreno (981,93m²).
- Será revisada diretriz considerando 1.092UH.

- **URBANIZAÇÃO**

  - Necessário preservar na Avenida Cidade de Santos 13m de largura conforme situação local na e Av. José Brumatti 14m de cada lado, com calçadas de 3m, compatíveis com a instalação de abrigo de ônibus.

- **CONTRAPARTIDA**

- Haverá cobrança de medida mitigadora em função da aprovação do EIV e RIT.

LEGALIZAÇÃO E DPP

➢ **ABASTECIMENTO SANITÁRIO**

- Diretrizes de SABESP solicitada para 820uh. Recebido em 07/11/2025.
  - Esgoto – Haverá reforço da rede em 200mm diâmetro, com extensão de 105m.
  - Agua – Haverá reforço da rede de em 225mm diâmetro, com extensão de 350m.
  - Será solicitado nova diretriz considerando 1.092uh.

➢ **DRENAGEM**

- Lançamento da drenagem na Av. Brumatti;
- Confirmada a não exigência de FNA em diretriz urbanística.

➢ **GRAPROHAB**

- Devido ao número de unidades, foi considerada aprovação em Graprohab após aprovação na municipalidade.

➢ **ÓRGÃOS DE PATRIMÔNIO HISTÓRICO**

- Municipal – Leg a confirmar, mas não enxergamos nenhum risco.
- Estadual – Condephaat: Leg a confirmar, mas não enxergamos nenhum risco.
- Federal – IPHAN: - Leg a confirmar, mas não enxergamos nenhum risco.

➢ **MOVIMENTAÇÃO DE TERRA**

- Será aprovado junto ao processo de licenciamento arbóreo

LEGALIZAÇÃO E DPP

➢ COMAER

- Necessário aprovação junto ao Comaer visto proximidade na superfície de decolagem do aeródromo do aeroporto de Guarulhos.
- AP respeita a altura definida na pré analise feita pela Flight.
    - Altura máxima permitida: 50 m
    - Atitude do topo: 821 m

➢ AVALIAÇÕES AMBIENTAIS

Contaminação de Solo

- Análise Preliminar realizada. Histórico de ocupação da área é potencial de contaminação.
- Necessária avaliação confirmatória com possibilidade de ocorrência pontual de contaminação por metais, já considerada na viabilidade e tratada por meio de impermeabilidade.

Arbóreo

- Regularização ambiental em diretriz urbanística, deferido para cancelamento do auto de infração.
- Laudo de vegetação identificou presença de maciço arbóreo em um talude com alta declividade. Como estratégia de negócios, decidimos pela não intervenção deste local em projeto.

Hidrografia

- O Imóvel não apresenta corpos d'água internos ao perímetro ou próximo.

➢ OUTROS ITENS NECESSÁRIOS/ESPECÍFICOS

- No momento, seguimos com doação de área para a Prefeitura e não com a doação em Pecúnia;
- Leg solicitará a prefeitura modificar a doação de área para a testada da Av. José Brumatti para ganharmos eficiência no projeto;
- Solicitada diretriz de gás encanado para a Comgás.

CRONOGRAMA PRÉVIO

Brumatti x Santos	dez/25	jan/26	fev/26	mar/26	abr/26	mai/26	jun/26	jul/26	ago/26	set/26	out/26	nov/26	dez/26	jan/27	fev/27	mar/27	abr/27	mai/27	jun/27
	1	2	3	4	5	6	7	8	9	10	11	12	13	14	15	16	17	18	19
SABESP	1	2																	
Ambiental (Confirmatória)	1	2	3																
Aprovação COMAER	1	2	3	4															
Hidrológico	1	2																	
Iphan	1																		
Tomb Municipal		1																	
CETESB - Contaminação							1	2	3	4									
DPP - AP		1																	
NEG - Comitê Ampliado	1																		
DPP - PL de AP	1																		
LINHA - PRE-KIT processo único		1	2	3	4														
PL - PL de EP						1													
LEG - NBR			1																
LEG - Aprovação Drenagem			1	2	3	4	5	6	7										
LEG - Aprovação supressão vegetação		1	2	3	4	5	6												
LEG - Pgto CRIT (10x)																		1	
NEG - Carta de enquadramento CEF		1																	
LEG - Certidão de caracterização Sec. Hab.		1																	
JUR - Certidão Isenção de ITBI						1													
LEG - Aprovação EIV/RIT		1	2	3	4	5	6												
LEG - Alvará de construção			1	2	3	4	5	6	7	8									
LEG - Aprovação GRAPRO											1	2	3	4	5	6			
JUR - Escritura e RI																1	2		
CRE - Contratação CEF															1	2	3	4	
NEG -Lançamento																			1

- **DESCRIÇÃO DO IMÓVEL: Matrícula nº 178.383 do 2º CRI de Guarulhos/SP**, localizado na Avenida José Brumatti, nº 2.373, Bairro de Lavras, Município de Guarulhos – Cadastro Municipal nº 064.11.07.0807.00.000 ("**Imóvel**").

- **PROPRIETÁRIAS TABULARES: (i) PRICILA FIORDELÍSIO DE CARVALHO** e **(ii) MAGDA FIORDELÍSIO –** as **Proprietárias** adquiriram o **Imóvel** por força da sentença proferida em 21/07/2023, nos autos da Ação de Usucapião (processo nº 1014787-34.2017.8.26.0224), a qual transitou em julgado em 14/09/2023, servindo como título hábil à aquisição originária da propriedade, sendo registrada, em 06/05/2024, sob o R.01 na Matrícula nº 178.383 do 2º Oficial de Registro de Imóveis de Guarulhos/SP, mesma data de abertura da referida matrícula.

- **CONSIDERAÇÕES JURÍDICAS SOBRE O IMÓVEL:**

  - **(a) Retificação:** De acordo com o parecer técnico enviado na data de 28/11/2025, caso optemos pela utilização da poligonal mais restritiva (matrícula), não haverá a necessidade de retificação. Referida poligonal foi delimitada de forma a respeitar integralmente os limites registrais vigentes, excluindo de seu perímetro qualquer interferência sobre áreas públicas ou imóveis confrontantes, constituindo, portanto, referência segura para avaliações subsequentes. Contudo, na hipótese de ampliação das áreas em razão de usucapião, poderemos seguir com a retificação. **(b) Loteamento:** Da análise da certidão vintenária da matrícula nº 178.383 e da anterior nº 31.732 do 2º Oficial de Registro de Imóveis de Guarulhos/SP, ambas emitidas em 31/10/2025, verifica-se que não constam sobre o **Imóvel** quaisquer ônus reais, gravames ou restrições, e, em que pese não haja a certificação quanto a possível loteamento, não constam nas matrículas quaisquer indicativos de "lote"; "loteamento" ou possíveis restrições construtivas. **(c) Desmembramento:** área técnica informou que o terreno será objeto de aprovação de desdobro da área. A companhia seguirá com o desdobro do atual imóvel em 02 áreas, sendo uma para o empreendimento e a outra objeto de doação ao Município. Terá doação para o Empreendimento Imobiliário; **(d) Área construída:** Na matrícula do **Imóvel** consta a indicação de terreno sem construção, enquanto na certidão de dados cadastrais emitida pela Municipalidade de Guarulhos/SP, em 20/10/2025, consta a **área construída de 41,93m²**, não sendo possível constatar se encontra regular diante da não apresentação da certidão de histórico de edificação emitida pela Municipalidade, cumpre esclarecer que o Oficial de Registro de Imóveis poderá, eventualmente, exigir a regularização da edificação e a averbação da área total construída na matrícula do Imóvel, por ocasião da averbação da futura demolição necessária à implantação do Empreendimento.

- **CONSIDERAÇÕES JURÍDICAS SOBRE O IMÓVEL:**

  - **(e) Impostos, taxas e Multas:** na Comarca de Guarulhos não há a emissão de certidão ou extrato relativo a multas e taxas, sendo emitida a certidão de tributos imobiliários, em 20/10/2025, constando débitos de Imposto sobre a Propriedade Predial e Territorial Urbana, no montante no valor de **R$ 368.392,63 (trezentos e sessenta e oito mil trezentos e noventa e dois reais e sessenta e três centavos),** inscritos em dívida ativa e abertos, sendo: (i) R$ 123.672,94, referente ao exercício de 2009; (ii) R$ 122.516,25, referente ao exercício de 2010 e (iii) R$ 122.203,44, referente ao exercício de 2011; **(f) Ônus e Gravames**: Não constam quaisquer ônus/gravames registrados na matrícula do **Imóvel**; **(g) Ocupação**: o **Imóvel** encontra-se locado para fins comerciais à Eltron Pereira da Silva, nos termos do Contrato de Locação não Residencial (comércio e estoque de materiais brutos), celebrado em 30/10/2019, pelo prazo de 36 (trinta e seis) meses, com início no dia 30/10/2019 e término no dia 30/10/2022, atualmente vigente por prazo indeterminado. Não obstante, nos termos da cláusula 4.6. do Contrato as Proprietárias se comprometeram a notificar formalmente o locatário sobre a venda, nos termos do artigo 27 da Lei nº 8.245/91, em até 10 (dez) dias contados da notificação sobre a superação das condições resolutivas previstas no Capítulo VI, item I. E, de acordo com a cláusula 4.6.1, as Proprietárias são obrigadas a entregar o Imóvel livre e desimpedido de quaisquer pessoas ou coisas, no ato da lavratura da escritura pública de compra e venda, desde que tenha realizado a comunicação da aprovação e superação das demais condições resolutivas, especificas e rescisórias em até 120 (cento e vinte) dias prévios à lavratura da escritura; **(h) Tombamento:** na Certidão de Tombamento Estadual (CONDEPHAAT), não constam decretos de tombamento incidentes sobre o **Imóvel**. Ressalta-se, contudo, que não foram apresentados a Certidão de Tombamento Municipal e o ofício emitido pelo IPHAN, embora solicitado, ainda não emitido; **(i) Desapropriação e Melhoramentos:** na Certidão de Desapropriação Municipal de Guarulhos e na Estadual (emitida no Departamento de Estradas de Rodagem), não constam decretos; projeto e/ou declaração de utilidade pública incidentes sobre o Imóvel. Ressalta-se, contudo, não foi apresentado a Certidão de inexistência de projeto e/ou declaração de utilidade pública, embora solicitado, ainda não emitida– Melhoramentos, e de acordo com a pesquisa realizada junto ao banco de dados da Superintendência SPIUNET (Sistema de Gerenciamento dos Imóveis de Uso Especial da União), SIAPA (Sistema Integrado de Administração Patrimonial) e sistema RFFSA, o **Imóvel** encontra-se situado dentro do perímetro do extinto Aldeamento Indígena de São Miguel e Guarulhos, de propriedade da União Federal, conforme Decreto - Lei nº 9.760, de 05 de Setembro de 1946, artigo 1º - parágrafo h. Entretanto, de acordo com o artigo 17 da MP nº 2.180 não consta interesse da União no Imóvel, em virtude da área não satisfazer nenhuma das 03 ressalvas previstas, quais sejam: "*A União não reivindicará o domínio de terras originárias de aldeamentos indígenas extintos anteriormente a 24 de fevereiro de 1891, ou confiscadas aos Jesuítas até aquela data, e desistirá de reivindicações que tenham como objeto referido domínio, salvo das áreas: I - afetadas a uso público comum e a uso especial da Administração Federal direta e indireta, inclusive as reservadas; II - cedidas pela União, ou por esta submetidas ao regime enfitêutico; e III - identificadas, como de domínio da União, por ato jurídico específico, administrativo ou judicial*".

- **CONSIDERAÇÕES SOBRE AS PROPRIETÁRIAS (DD Concluída):**

  - **Certidões forenses:** Consta em nome das **Proprietárias** a Ação de Usucapião nº 0078627-11.2012.8.26.0224, em trâmite perante a 8ª Vara Cível do Foro de Guarulhos, movida, em 24/01/2024, por Armando Salgado Leitão ("Ação de Usucapião").
    Referida ação pleiteia parte de imóvel, com 68.000,00m², da área aproximada de seis alqueires, situada no lugar denominado "Potim", Bairro das Lavras, Guarulhos, Estado de São Paulo (Av. Jose Brumatti Antiga Estrada de Itaverava, Av. Cidade de Santos - Bairro lavras, Guarulhos), objeto da matrícula nº 31.732, do 2º Registro Imobiliário de Guarulhos, sob inscrição cadastral n.sº 064.11.07.0278.01.001 / 01.002 / 01.003 / 01.004 / 01.005 / 01.006.
    Em 02/02/2015, as Proprietárias manifestaram nos autos informando que (i) são coproprietárias de uma área maior, em comum, com Saturnino Nepomuceno, Armando Salgado Leitão e Georgio Nicoli, da matrícula nº 31.732 do 2º Registro Imobiliários de Guarulhos; que (ii) embora em condomínio, desde a aquisição, cada condômino vem exercendo a posse direta, exclusiva e individualizada sobre a sua área, respeitando entre eles as divisas que há mais de décadas permanecem inalteradas; (iii) não se opõem ao pedido formulado pelos condôminos Armando Salgado Leitão e outros, sobre uma área de 68.078,66m², cuja posse exclusiva e individualizada vêm exercendo, desde que sejam respeitadas as divisas da área de 20.000,00m² de posse absoluta dos contestantes, pleiteando por esclarecimentos do perito acerca da área descrita na inicial, se eventualmente ultrapassa a divisa da parte que os contestantes exercem posse com exclusividade e sem oposição dos demais condôminos, não sendo respondido em laudos posteriores.
    Não obstante, ainda que a matrícula do Imóvel pretendido tenha sido aberta em 06/05/2024 — ou seja, em data posterior à formulação da indagação pelas Proprietárias — presume-se que a área por elas demarcada no pedido de usucapião foi deferida, não havendo, até o momento, registros de controvérsias relativas a essa área perante terceiros.
    Dessa forma, foi recomendado a realização de levantamento planialtimétrico da área usucapida e análise das descrições dos laudos Anexos ao Parecer, por equipe técnica especializada, com o objetivo de confirmar a inexistência de sobreposições com áreas eventualmente reivindicadas por terceiros.
    Após a realização de estudos técnicos, com a Castro, concluímos que não há interferência na área, não havendo risco ao negócio.

  - **Certidões fiscais:** Em nome da **Proprietária PRICILA FIORDELÍSIO DE CARVALHO** a certidão da Receita Federal foi emitida positiva com efeito de negativa, constando débitos administrados pela Secretaria da Receita Federal do Brasil (RFB), com exigibilidade suspensa, no montante de **R$ 3.117,97 (três mil cento e dezessete reais e noventa e sete centavos)**, sendo relativos aos tributos de: (i) IRPF, para o exercício de 2025, no valor de R$ 2.766,94 (dois mil setecentos e sessenta e seis reais e noventa e quatro); (ii) CP-SEGUR., para o exercício de 2025, no valor de 166,23 (cento e sessenta e seis reais e vinte e três centavos) e (iii) CP-PATRONAL, para o exercício de 2025, no valor de R$ 184,80 (cento e oitenta e quatro reais e oitenta centavos).

- **CONSIDERAÇÕES SOBRE AS PROPRIETÁRIAS (DD Concluída):**

  - **Certidões pendentes:** as Certidões de Interdição, Tutelas e Curatelas, emitida pelo Cartório de Registro Civil da Comarca de Guarulhos/SP em nome das **Proprietárias** não foram apresentadas.

- **CONSIDERAÇÕES SOBRE AS EMPRESAS DAS PROPRIETÁRIAS:**

  - Das pesquisas de participação societária, foram identificadas as seguintes sociedades nas quais as **Proprietárias** fazem ou fizeram parte do quadro societário nos últimos 5 (cinco) anos: **(i) ROTISSERIE CAPELINE LTDA.** - NIRE 35206611144 – matriz e da filial, conforme Cadastro Nacional da Pessoa Jurídica, a empresa foi baixada em 21/09/2023, em decorrência da extinção por encerramento liquidação voluntária e **(ii) M. P. PARTICIPACOES LIMITADA** - indicada no 03º Cartório de Registro de Títulos e Documentos e Civil de Pessoas Jurídicas de São Paulo (RTD) sob nº 243.384/95, as quais em atenção às certidões administrativas, forenses e federais, não foram constatados apontamentos com condão de impactar a aquisição pretendida por V.Sas.

- **CONCLUSÃO.:**

Ao concluirmos a Due Diligence, constatamos que, embora tenha sido apresentada Certidão Positiva com Efeitos de Negativa em nome da VENDEDORA PRICILA FIORDELÍSIO DE CARVALHO, consta débito de R$ 3.117,97. Referida quantia deverá ter sua quitação acompanhada até a data de lavratura da escritura. Não constaram apontamentos relevantes em relação aos demais vendedores.
Até o momento não foi constatado nenhum tipo de gravame ou ônus na matrícula do imóvel. Constam débitos de IPTU no valor de R$ 368.392,63, que serão quitados pela vendedora até a data de lavratura da escritura. O imóvel segue locado para fins comerciais, por prazo indeterminado, sendo que sua desocupação ocorrerá até a data de lavratura da escritura, o que precisa ser acompanhado pela companhia.
Constatada a existência de processo de usucapião nº 0078627-11.2012.8.26.0224, ingressado pelo vizinho, solicitando parte do imóvel, tendo como base demarcação anteriormente elaborada. Após a conclusão das análises, com a realização de novo levantamento técnico e topográfico, é possível confirmar que não tem relação com a área objeto da presente aquisição. Desta forma, conclui-se que, no momento, do ponto de vista jurídico, não há óbices que comprometam a presente transação.