Tenda

sua próxima conquista

Comitê Essencial de Reversão s/ Reneg

Regional: Itaquaquecetuba

Projeto: Cuiabinho

Data Comitê: 08/12/2025

One Page – Cuiabinho

Destaques

[1]

Cidade	Itaquaquecetuba	**Mancha de demanda**	SP - ITA - Itaquaquecetuba
Regional	SPRM	**Cluster MPR**	1 - Vermelho
Cenário de Aprovação	Aprovação	**Tipo de Aprovação**	Consolidado
Fase Anterior	N/A		
Tipo de Comitê	Reversão Essencial s/Reneg	**Versão da VF**	Versão 1.0: Dez

[2]

Unidades (Fases)	1140 (2)	**CA Máx | Proj**	3,5 | 3,0
Unidades com Vaga (%)	267 (23%)	**Escritura | Lançamento**	mar/27 | jun/27
Unidades com Varandas (%)	0 (0%)	**Tipologia**	F2E Plus - Concreto

[3]

Valor Líquido do Terreno (% VGV)	4.128 (1,6%)	**Un. Perm. Fís (% Ter)**	0 (0,0%)
Cash (Correção)	0 (N/A)	**%VGV Perm Fin Líquida (% Ter)**	1,6% (100,0%)
Valor R$/m²	360	**VAR (%VGV)**	000 (0,0%)

Custo Construção (%VGV)	119.109 (46,6%)	**Indireto Unit.**	19.754
Prazo da Obra (meses)	23	**Torre Unit.**	63.301
Custo Total Unit. | Corrigido (LPU):	104.482 | 104.967 (94)	**Infra Unit.**	10.257
Início de Obra	dez-27	**Fundação Unit.**	9.580

[4]

Preço Nominal Unit.	224.338	**VSO**	32
Preço Raso Unit.	205.299	**Referência**	Vision
Avaliação Unit.	249.113	**Renda (% em RET 1%)**	2.924 (44,1%)

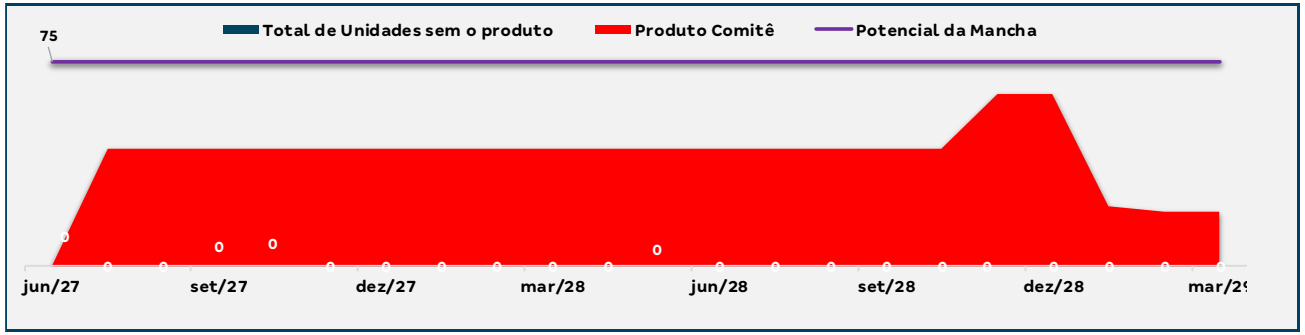

[5]

LI (Régua):	**23,7% (20,0%)**	**Margem Bruta Econômica:**	42,1%
LI Resiliência:	17,7% (N/A)	**Margem Rasa Econômica:**	36,0%
Margem Bruta REF:	45,2%	**Margem Contribuição Econômica:**	30,6%
Margem Rasa REF:	**40,1%**	**Exposição (% VGV):**	19.604 (7,0%)
TIR:	135,3%	**VGV Total:**	**255.746**
Payback Contingente (21 m) :	**20 m/ (-1 m)**	**Ger. Caixa 12 meses (R$):**	-
Payback Consolidado:	20	**Ger. Caixa 24 meses (R$):**	(6.873)

[0] Contexto: O terreno foi aprovado no Comitê Essencial em jun/25 com 499UH. Com a nova legislação municipal aprovada pela Câmara em 02/12 e publicada em 08/12, refizemos o projeto de acordo com os novos parâmetros e submetemos a este Comitê Essencial de reversão com cancelamento integral do book anterior e aprovação deste novo; o projeto teve aumento expressivo de unidades e de rentabilidade pois o vendedor não participa do ganho, de acordo com a condição de compra estabelecida contratualmente; **Obs. Top 3 mudanças regulatórias**: redução de vagas de 50% carro para 23% carro+10% moto; sem exigência de lazer mínimo; e sem limitador de 499UH em lotes a partir de 10mil m².

[1] Localização: Estrada do Cuiabá, Itaquaquecetuba (RMSP), região onde nossa última entrega ocorreu em 2017 (Veredas de Itaquá).

[2] Implantação: Terreno total de 73 mil m², com desmembramento de um lote de 12.500 m² para nosso condomínio, previsto com 1.140 UH (T+25), e agora faseado com 776/fase 1 e 364/fase 2; projeto atingiu sobre a área líquida um bom CA de 2,96X (85%) de um máx permitido de 3,5X.

[3] Condição Comercial:

a) 100% em permuta financeira equivalente a <u>fração fixa e não variável</u> de 20 unidades; sobre o valor desta permuta bruta estimado no contrato em 4,6MM, será descontado o percentual de 8%; Na viabilidade este valor representa atualmente 1,61% sob a receita bruta e 1,75% sob a receita líquida estimados em R$ 4,1MM;

b) Não há condição de preço mínimo, de correção ou prazo de quitação, e a garantia é com confissão de dívida, e sem corretagem.

Obs.: aproximadamente R$ 112/CA e R$ 330/m² (base valor terreno de 4,1MM)

[4] Preço de Venda: Sem lançamentos há 9 anos na região, realizamos estudo com Ciclo e IM: 236k nominal com vaga carro e 217k de raso; 218k nominal sem vaga e 199k de raso. Mesmo assim, permanecemos abaixo do último lançamento MRV (T+4), com preços entre 254k e 229k, respectivamente, em área com infraestrutura inferior.

[5] Resultado: Projeto acima da régua de 20% de LI e com quase todos os estudos técnicos concluídos.

Pareceres

Análise da Mancha e Implantação

Prospecção

Operações

Incorporação

Inteligência de Mercado

Financeiro

Anexos

Pareceres

Área	Riscos Associados	Parecer	Criticidade
Jurídico	Não foram identificados gravames, restrições, ações judiciais relevantes ou passivos capazes de comprometer a segurança jurídica da operação.	Ok	
Legalização	Apesar de já termos lançado no município anteriormente, a aprovação do novo Plano Diretor e da nova LUOPS nos forçou a reanalisar toda a legislação nova e a termos diversas conversas com as Secretarias de Planejamento e de Habitação sobre o fluxo de aprovações, o que não nos causa preocupação. O processo exige desdobro do terreno e doação de área institucional. Quanto à contrapartida financeira, apesar de o regramento legal ainda não estar estabelecido, foi sinalizado um valor aproximado de R$ 930 mil, calculado com base na área total do empreendimento. Será necessária a descaracterização de APP para implantação do projeto conforme EM.	Ok	
DPP	Sem riscos associados	Ok	
Inteligência de mercado	IM avalia o Preço Vision como factível.	Ok	
Comercial/Ciclo	Ciclo avaliou Preço e VSO como factíveis. O projeto está em uma região estratégica na borda de São Paulo, e consolidada com diversos projetos da Tenda. Os concorrentes existentes possuem preços mais altos, não concorrendo diretamente com o nosso público.	Ok	
Estudos Econômicos	Não Há.	Ok	

Pareceres

Análise da Mancha e Implantação

Prospecção

Operações

Incorporação

Inteligência de Mercado

Financeiro

Anexos

Localização – Estrada do Cuiabá – Jardim Caiubi – Itaquaquecetuba- SP

Rei Lar Supermercados

E. E. Dr Ervin Horvath

Unidade de Pronto Atendimento 24h

Higa's Supermercados

Escola Estadual Joaquim Gonçalves

Complexo Esportivo Rei Pelé (CEC)

Padaria JK

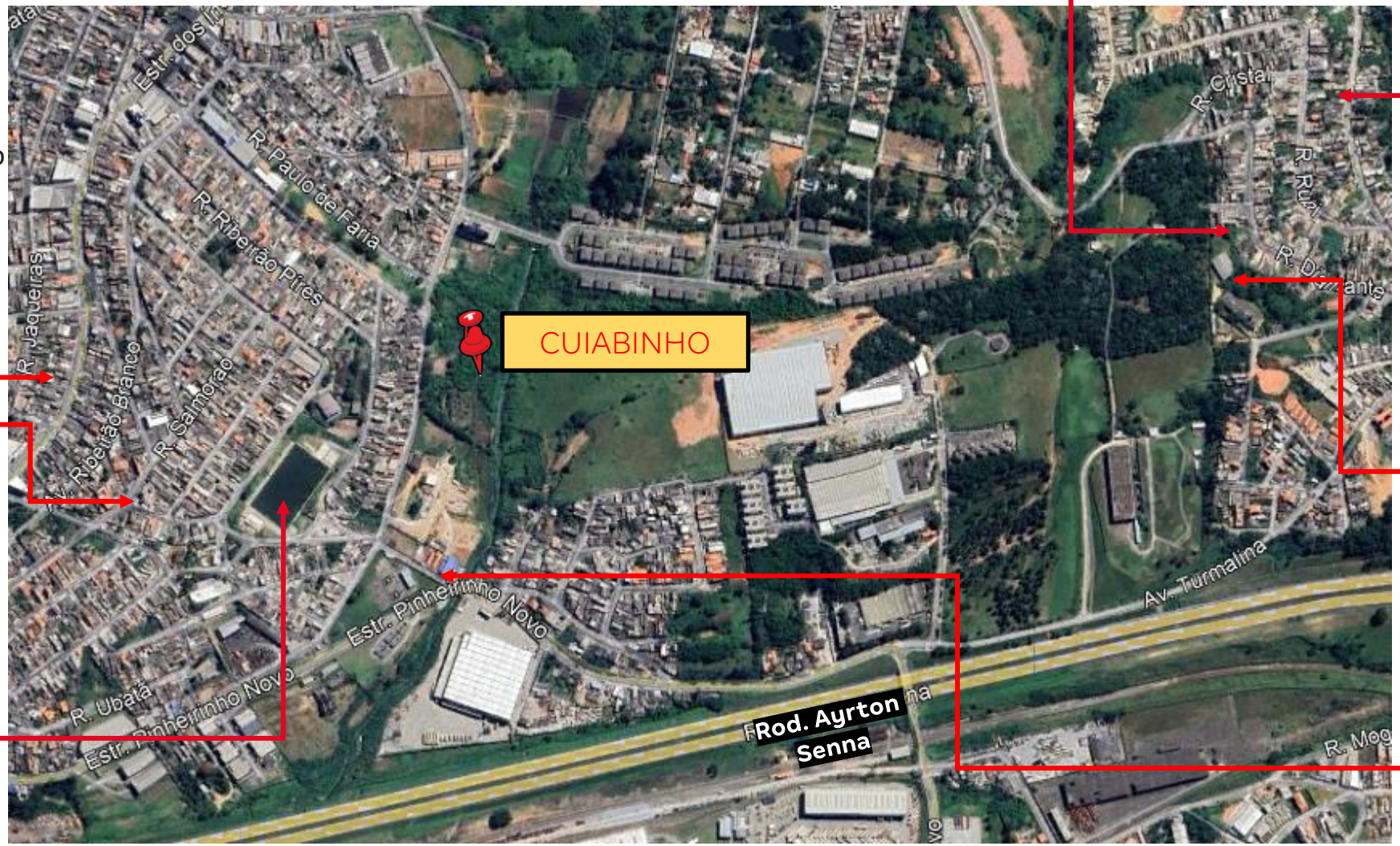

Localização – Estrada do Cuiabá – Jardim Caiubi – Itaquaquecetuba- SP

Área a ser desmembrada (aproximada)

Área total

Mancha de Demanda

MANCHAS DE DEMANDA • ITA – Itaquaquecetuba
Landbank 1. Cuiabinho

Cluster MPR – (Comitê)
Cluster 1 - Vermelho

Região
Metropolitana

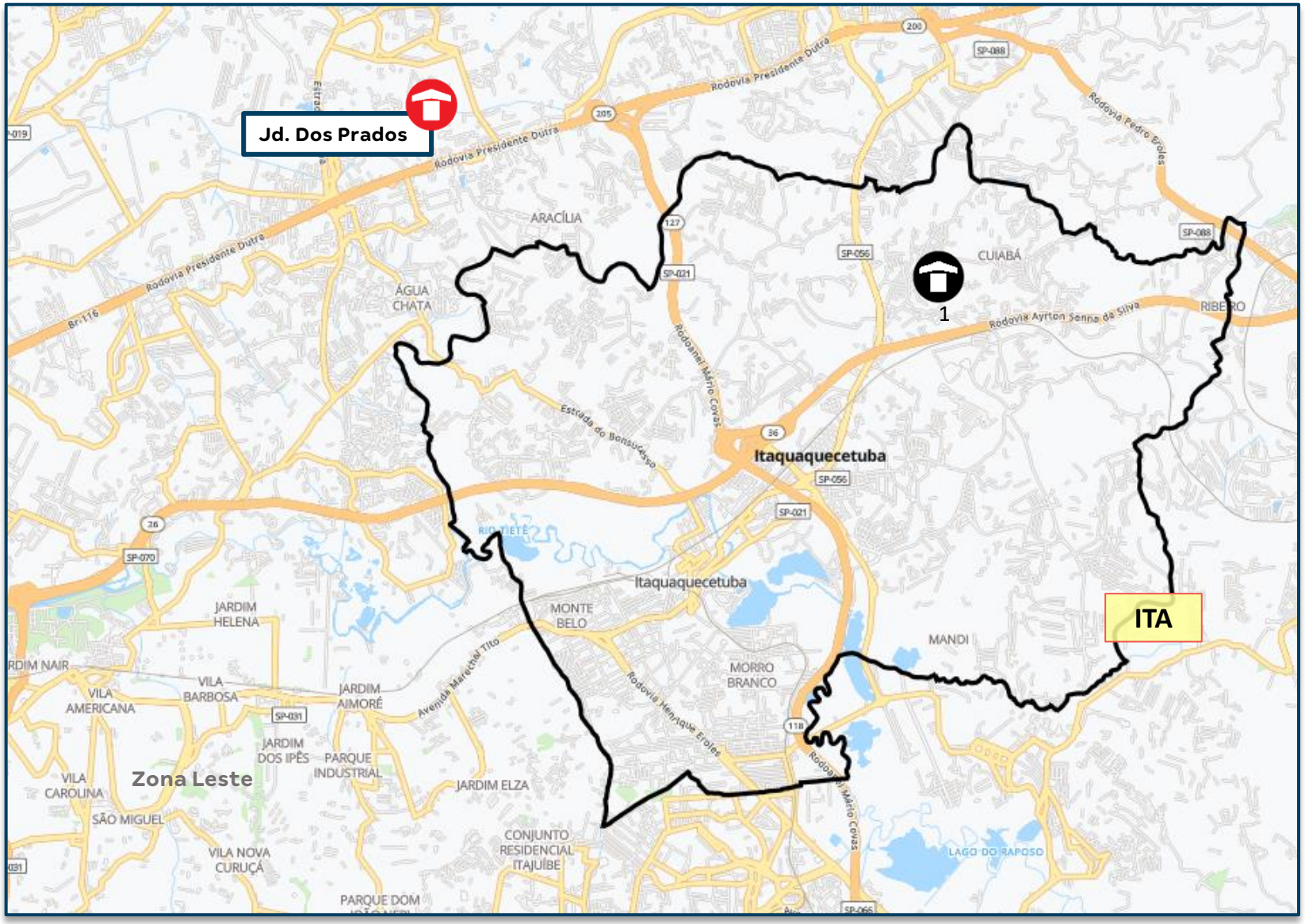

Lançados *LandBank* *Comitê*

PRODUTO

Projeto Cuiabinho
Comitê Essencial

Informações Gerais		
Terreno	Área terreno	12.500,28m²
	Menor poligonal	12.500,28m²
	App/fna	Sim (20,30m²) | Sim – (2,47m²)
	Reserva de calçada/ melhoramento viário	Não | Não
	Área liquida	12.477,51m²
Diretrizes Urbanísticas	Zoneamento	ZQU
	Ca máximo Total	3,50
	Ca básico	1,00
	Ca projetado	2,96
	Ca líquido	2,96
	Gabarito máximo	T + 25
Geral	Total uh	1.140
	Total de vagas exigido	380 vagas total (1/3 – 70% carros e 30% motos)
	Total de vagas projetado	267 vagas de carros (70%) 116 vagas de motos (30%)
Tipologia	Tipologia	Modular com elevador
	Gabarito	T+25
	Lâmina	01 12pp, 01 14pp e 01 18pp
	Área privativa	32,42m²
Condomínio	Unidade pcd	23 (2%)
	Unidade lazer|técnica	02|02
	Torre	03
	Fase	02
Lazer	Lazer Interno	03-Salão de Festas, 04-Fitness, 05-brinquedoteca.
	Lazer Externo	01-Salão de festas sem churrasqueira, 02- Churrasqueira gourmet.

Projeto com vagas ao tempo; durante a fase de desenvolvimento, estudaremos outras opções de implantação que levem em consideração o atingimento máx. do CA com incremento de unidades e outras alternativas de torre (gabarito e/ou lâmina do pavto) e inclusive um Edifício Garagem.

1. **FNA Drenagem**
2. **APP**

PRODUTO

Projeto Cuiabinho
Comitê Essencial

	Descrição	Criticidade	Observação
Usabilidade	**Acesso Empreendimento**		
	Percurso do pedestre até torre		
Diferencial produto	**Faixa de renda**	02	
	Prime	Não	
	Supercondomínio	Sim	*1.140 unidades*
	Atributos Infra	Não	
	Atributos Torre	Não	
	Edifício Garagem	Não	
Material Analisado	**Ficha Briefing**		
	Diretriz Sabesp		*O estudo contempla elevatória de esgoto, e ligação de esgoto depende de conclusão de obras da SABESP*
	Planialtimétrico		
Projeto	**Área Liquida**		*A área será desmembrada de um terreno maior. Os limites considerados no estudo poderão sofrer ajustes conforme a Faixa Não Edificável (FNA) relacionada à rede de esgoto que atravessa o imóvel, localizada no limite da poligonal aprovada pela Sabesp. Além disso, poderão ocorrer alterações em função das análises da Prefeitura e da definição da Área de Preservação Permanente (APP).*

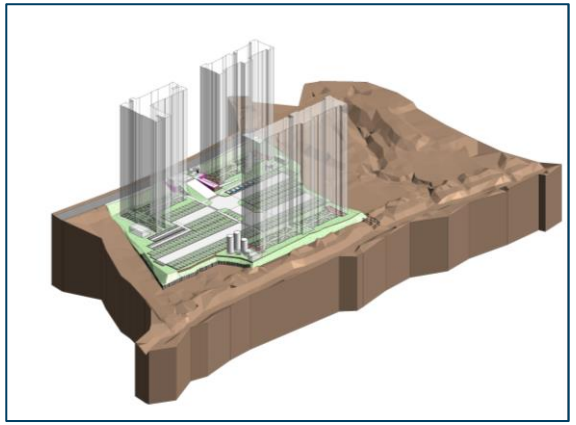

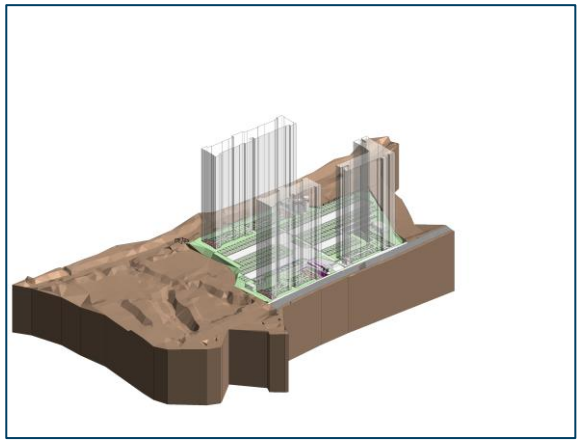

Pareceres

Análise da Mancha e Implantação

Prospecção

Operações

Incorporação

Inteligência de Mercado

Financeiro

Anexos

Condições do Negócio

- VALOR DO NEGÓCIO / CONDIÇÃO COMERCIAL
- 100% em permuta financeira equivalente a fração fixa e não variável de 20 unidades; sobre o valor desta permuta bruta estimado no contrato em 4,6MM, será descontado o percentual de 8%; Na viabilidade este valor representa atualmente 1,61% sob a receita bruta e 1,75% sob a receita líquida estimados em R$ 4,1MM;
- Não há condição de preço mínimo, de correção ou prazo de quitação;
- Como a negociação fixou a permuta financeira equivalente a 20unid, o permutante não participará do ganho de uh que tivemos;
- Obs.: aproximadamente R$ 112/CA e R$ 330/m² (base valor terreno de 4,1MM)
- Garantia: Confissão de dívida.
- PRAZOS CONTRATUAIS
- Etapa I: Prazo 12 meses para baixa da hipoteca pelos vendedores (quitada em nov/25)
- Etapa II: Em até 6 meses da Etapa I para resolutivas técnica, jurídica e financeira; (limite mai/26)
- Etapa III: Em até 12 meses após a superação da Etapa II para aprovação de projeto de desmembramento:
- Etapa IV: Em até 12 meses após a superação da Etapa III para aprovação de projeto, contratação CEF, análise técnica, financeira e comercial para o lançamento do empreendimento;
- PREVISÃO EM CONTRATO DE DESCONTOS DO PREÇO
- Limite pré aprovado de 5% do valor do negócio (R$ 230.000,00) para regularizações que se fizerem necessárias à aprovação do projeto e realização dos demais atos necessários à consecução do Empreendimento perante a Prefeitura Municipal e os demais órgãos competentes
- Limite pré aprovado de 5% do valor do negócio (R$ 230.000,00) para adoção de medidas visando sanar os Passivos Ambientais, tais como, exemplificativamente, sem qualquer limitação, medidas visando remediar/descontaminar/conter contaminação, plano de intervenção e/ou reabilitação
- TAC (Termos de Ajustamento de Conduta)/TCA (Termo de Compromisso Ambiental) no intuito de reparar o dano ambiental, sem limite de valor
- GARANTIAS
- Proprietário: Confissão de dívida
- Tenda: N/A
- CORRETAGEM
- Por conta dos vendedores

Pareceres

Análise da Mancha e Implantação

Prospecção

Operações

Incorporação

Inteligência de Mercado

Financeiro

Anexos

Custo de Construção – SIMULADOR

PARÂMETROS					Versão:	set-25 R00
Empreendimento:	Cuiabinho F1				INCC base:	1.216,71
Produto / Selo:	F2E+ Modular	Contenção:	Nível 2		Prazo pré forma:	5,7
Pavimentos Médio:	26	Terraplenagem:	Nível 3		Prazo forma:	8,0
Torres:	2	Varanda %:	0%		Prazo pós Forma:	9,0
PPs médio:	15,0	Piscina:	Não		Prazo total:	23,0
Unidades Construídas:	780	ETE:	Não		EEE:	Sim

PARÂMETROS					Versão:	set-25 R00
Empreendimento:	Cuiabinho F2				INCC base:	1.216,71
Produto / Selo:	F2E+ Modular	Contenção:	Nível 1		Prazo pré forma:	5,7
Pavimentos Médio:	26	Terraplenagem:	Nível 1		Prazo forma:	3,8
Torres:	1	Varanda %:	0%		Prazo pós Forma:	9,0
PPs médio:	14,0	Piscina:	Não		Prazo total:	19,0
Unidades Construídas:	364	ETE:	Não		EEE:	Não

Infra Externa

Viário (m):	46	Extensão Esgoto (m):	30
Drenagem (m):	30	Extensão Água (m):	41

CRITÉRIOS DE INPUT DO SIMULADOR

ETE: Retirada de acordo com a diretriz da Sabesp e validação de Getec/Leg
EEE: Será necessário para lançar o esgoto para a rua

Custo de Construção – SIMULADOR

DADOS DA OBRA		BASES		PRAZOS DE OBRA	
Regional:	SP	Data:	dezembro-25	Pré Forma:	5,7 meses
Endereço:	Cuiabinho F1	Revisão:	R00	Estrutura:	8,0 meses
Total de UH:	**780**	LPU:	LPU 94	Pós Forma:	9,0 meses
Total Torres:	2	LVS:	agosto-25	**TOTAL:**	**23,0 meses**
Produtos:	F2E+ Modular	INCC:	1.216,706		
Tipologia:	MODULAR 10PP/16PP T+15			Jogos de Formas:	2
				Takt:	2+2

CUSTOS DE CONSTRUÇÃO

	CUSTO	R$ / UND
CUSTO TOTAL I	**R$ 79.564.026**	**R$ 102.531**
INDIRETO	R$ 13.461.329	R$ 17.347
TORRE	R$ 49.216.078	R$ 63.423
INFRA	R$ 7.945.384	R$ 10.239
FUNDAÇÃO	R$ 7.453.107	R$ 9.605
ETE	R$ 0	R$ 0
EEE	R$ 254.407	R$ 328
CONTENÇÃO	R$ 370.028	R$ 477
TERRAPLENAGEM	R$ 863.694	R$ 1.113

DADOS DA OBRA		BASES		PRAZOS DE OBRA	
Regional:	SP	Data:	dezembro-25	Pré Forma:	5,7 meses
Endereço:	Cuiabinho F2	Revisão:	R00	Estrutura:	3,8 meses
Total de UH:	**364**	LPU:	LPU 94	Pós Forma:	9,0 meses
Total Torres:	1	LVS:	agosto-25	**TOTAL:**	**19,0 meses**
Produtos:	F2E+ Modular	INCC:	1.216,706		
Tipologia:	MODULAR 10PP/16PP T+15			Jogos de Formas:	2
				Takt:	2+2

CUSTOS DE CONSTRUÇÃO

	CUSTO	R$ / UND
CUSTO TOTAL I	**R$ 38.526.268**	**R$ 105.841**
INDIRETO	R$ 8.064.736	R$ 22.156
TORRE	R$ 22.997.193	R$ 63.179
INFRA	R$ 3.740.272	R$ 10.275
FUNDAÇÃO	R$ 3.478.117	R$ 9.555
ETE	R$ 0	R$ 0
EEE	R$ 0	R$ 0
CONTENÇÃO	R$ 32.614	R$ 90
TERRAPLENAGEM	R$ 213.337	R$ 586

Custo de INFRA – SIMULADOR

CUSTO TOTAL II	R$ 740.026	R$ 894
VIÁRIO	R$ 102.361	R$ 124
DRENAGEM	R$ 65.000	R$ 79
EXTENSÃO ELÉTRICA	R$ 150.000	R$ 181
EXTENSÃO HIDRÁULICA	R$ 422.665	R$ 510

CRITÉRIOS DE INPUT DO SIMULADOR

- Viário: considerada toda a testada do empreendimento
- Drenagem: lançamento por gravidade no córrego dos fundos
- Pontos de interligação de água e esgoto de acordo com a diretriz da Sabesp

- Ponto de ligação de água
- Ponto de ligação de esgoto
- Saída da drenagem

Pareceres

Análise da Mancha e Implantação

Prospecção

Operações

Incorporação

Inteligência de Mercado

Financeiro

Anexos

Demanda e Distribuição da Mancha

Potencial de Demanda			Lançados		Lanç + Landbank	
Mancha	CÓD.	Shr.	ANO	MÊS	ANO	MÊS
Itaquaquecetuba	ITA	30%	749	62	898	75

aixas MCMV	Empreendimento	Renda	Lançamento	jun/27	jul/27	ago/27	set/27	out/27	nov/27	dez/27	jan/28	fev/28	mar/28	abr/28	mai/28	jun/28	jul/28	ago/28	set/28	out/28	nov/28	dez/28	jan/29	fev/29	mar/29
Faixa 2	Cuiabinho F1	2.924	jun-27		43	43	43	43	43	43	43	43	43	43	43	43	43	43	43	43	43	43	2		
Faixa 2	Cuiabinho F2	2.924	nov-28																			20	20	20	20
Total de Vendas Lançados				0	0	0	0	0	0	0	0	0	0	0	0	0	0	0	0	0	0	0	0	0	0
Total de Vendas Lançados + Landbank				0	43	43	43	43	43	43	43	43	43	43	43	43	43	43	43	43	63	63	22	20	20
Total Mancha | Faixa 1					0%	0%	0%	0%	0%	0%	0%	0%	0%	0%	0%	0%	0%	0%	0%	0%	0%	0%	0%	0%	0%
Total Mancha | Faixa 2					100%	100%	100%	100%	100%	100%	100%	100%	100%	100%	100%	100%	100%	100%	100%	100%	100%	100%	100%	100%	100%
Total Mancha | Faixa 3					0%	0%	0%	0%	0%	0%	0%	0%	0%	0%	0%	0%	0%	0%	0%	0%	0%	0%	0%	0%	0%

Parecer de I.M sobre a mancha:

O projeto analisado em comitê está em linha com o potencial teórico de demanda calculado para a mancha. (Total Lanç + Landbank)

Canibalização:

Sem Risco de Canibalização

Cuiabinho F1 | Mapa Concorrência

		Cuiabinho F1	Mirante Da Colina	Mirante Do Campo
		TENDA	MRV	MRV
	Distância Tenda (km)		5,81Km	5,32 Km
Região 1 Km	População	20.261	22.274	9.957
	Dens. Demográfica	6.491	7.136	3.190
	Renda (R$)	3.366	2.892	3.864
	Classe Social	C1 (2.7k a 4.6k)	C1 (2.7k a 4.6k)	C1 (2.7k a 4.6k)
	PEA Dia	6.494	6.869	8.973
Quantitativo	Lançamento	ago/27	10/2024	12/2023
	Unidades	776	480	240
	Estoque	776	166	0
	VSO	43	22	25
	Stockout	18	7	0
Qualitativo	Condomínios	1	1	1
	Torres	2	10	6
	Gabarito	T+17	T+4	T+4
	Plantas (m²)	32m²	40,82m² e 40,82m²	40,88m² e 40,83m²
	Tipologia	2 Dorms	2 Dorms	2 Dorms
	Opções	Não	Garden	Garden
	Varanda	Não	Não	Não
	Vagas	29% de Vagas	Com vaga	100% Com vaga
	Lazer	2 Salão de festas com churrasqueira - churrasqueira gourmet	Tem Garden, Bosque, Campo de Futebol, Cinema, Fireplace, Praça, Salão de Jogos,	Tem Garden, Bosque, Campo de Futebol, Cinema, Praça, Salão de Jogos, Sauna Seca,

Farol Renda
Acima de 300
Entre 0 e 300
Abaixo de 0

Diagnóstico Concorrência

- Os empreendimentos mapeados são da MRV e estão localizados fora do raio de 5 km.
- O empreendimento Mirante do Campo não possui unidades disponíveis. Mas o projeto conseguiu atrair um perfil de cliente com renda superior ao estimado no parecer, mantendo um volume de vendas próximo ao previsto para um produto da Tenda.
- Já o empreendimento Mirante da Colina, localizado em uma região similar atua com um target de preço e renda acima do estimado no parecer.

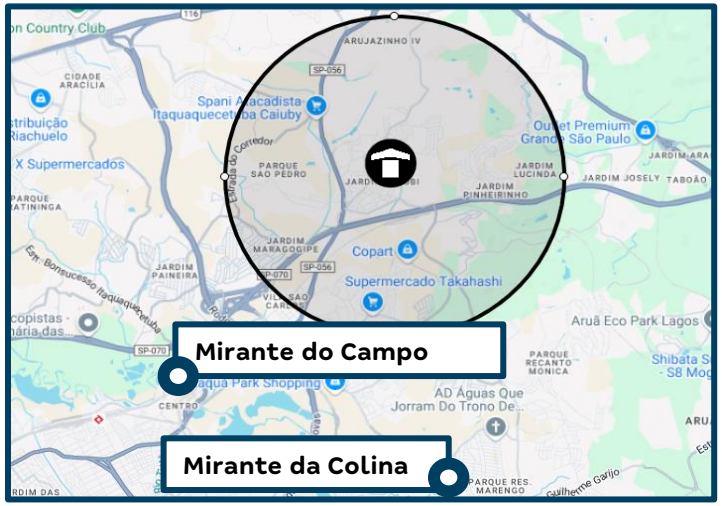

-	Cuiabinho F1					Mirante Da Colina - Com Emcash					Mirante Do Campo - Sem Emcash			
Tipologias	Avaliação	Preço Nominal	CEF	Renda	% Unidades	Avaliação	Preço Nominal	CEF	Renda	Farol	Preço Nominal	CEF	Renda	Farol
HIS	245.000	218.427	171.592	2.681	70%	245.280	229.690	173.778	3.030	●				
HIS - Vg Moto	251.000	223.620	175.613	3.199	1%									
HIS - Vg Carro	260.000	236.675	185.858	3.499	29%	260.000	253.490	188.902	4.050	●	238.323	190.658	4.138	●
Garden | Vg Carro						285.600	266.890	198.029	4.260	-				

Simulação de Preço

Informações Viabilidade

Projeto:	Cuiabinho F1					
Tipo:	**HIS**		**HIS - Vg Moto**		**HIS - Vg Carro**	
Método	**Vision**		**Vision**		**Vision**	
Avaliação	245.000		251.000		260.000	
Renda Inicial (VF)	2.681		3.199		3.499	
Renda Final*	-		-		-	
% RET1	50%		50%		25%	
Tipo:	**VF**	**R$**	**VF**	**R$**	**VF**	**R$**
Ato	0,89	2.373	0,74	2.359	0,69	2.399
FGTS	0,72	1.918	0,62	1.999	0,65	2.257
Financiamento	97,78%	155.453	96,06%	167.564	95,70%	179.735
Subsídio	92,99%	14.221	112,48%	6.050	137,80%	3.866
Prazo de Pró-soluto	28	28	28	28	28	28
Pró-Soluto	94,04%	25.648	82,16%	26.740	82,99%	29.540
Preço Raso (RS)	199.613	199.613	204.712	204.712	217.797	217.797
TCD	69,62%	18.814	58,64%	18.908	53,52%	18.878
VSO	29	29	1	1	13	13
Preço de Venda	**218.427**	**218.427**	**223.620**	**223.620**	**236.675**	**236.675**
Elasticidade	0,000%	0,000%	0,000%	0,000%	0,000%	0,000%
Preço de Venda Final	**218.427**	**218.427**	**223.620**	**223.620**	**236.675**	**236.675**
Preço Raso (R$)	**199.613**		**204.712**		**217.797**	
% de Raso	**91,39%**		**91,54%**		**92,02%**	
BP25 - Não Inflacionado	-		-		-	
BP25 - Inflacionado	-		-		-	

Análise de Preço

Informações Viabilidade

Projeto:	Cuiabinho F1	
Tipo:	**Faixa 2**	
Método	**Vision**	
Avaliação	249.411	
Renda Inicial (VF)	2.924	
Renda Final*	-	
Tipo:	**VF**	**R$**
Ato	0,83	2.380
FGTS	0,69	2.017
Financiamento	97,16%	162.618
Subsídio	106,18%	11.134
Prazo de Pró-soluto	28	28
Pró-Soluto	90,71%	26.788
Preço Raso (RS)	204.938	204.938
TCD	64,84%	18.834
VSO	43	43
Preço de Venda	**223.772**	**223.772**
Elasticidade	0,000%	0,000%
Preço de Venda Final	**223.772**	**223.772**
Preço Raso (R$)	**204.938**	
% de Raso	**91,58%**	
Raso Todas as Fases	**205.299**	
Nominal Todas as Fases	**224.338**	

1

Análise de Riscos

Farol IM

IM avalia o Preço Vision como **factível**.

1) Apesar de ser o primeiro empreendimento na mancha, com base no bom desempenho dos concorrentes, entendemos que o preço do Vision está adequado para atingir o volume de vendas esperado.

Conforme consta no slide "Panorama de Concorrência", não foi mapeado concorrente dentro do raio de 5Km. Os empreendimentos mencionados estão localizados fora desse raio, no município de Itaquaquecetuba. Mesmo assim, apresentam um target de preço e renda acima do estimado no parecer.

Abaixo segue o comparativo de preço do Jd. Dos Prados (Tenda), embora ele esteja localizado em outro município (Guarulhos), o projeto está em uma região metropolitana similar ao do Cuiabinho (vide o próximo slide), superando o volume de vendas projetado para comitê.

	Preço Real					Preço Normalizado (28m)	
Mancha	Avaliação	Preço Raso	enda Mediar	VSO	PSOL	Δ PSOL	Preço Raso
Jd. Dos Prados	234.578	210.331	3.114	56	30	-2.383	207.948
Cuiabinho F1	249.411	204.938	2.924	43	28	-	204.938

Análise de Preço

Abaixo segue o comparativo entre os empreendimentos Cuiabinho e Jd. Bonsucesso (Tenda). Apesar de estarem localizados em regiões distintas, ambos apresentam dados sociodemográficos similares, especialmente no que se refere à renda média e classe social predominante.

Empreendimentos	Cuiabinho	Jd. Bonsucesso
População	20.261	15.203
Dens. Demográfica	6.491	4.862
Renda	3.366	3.514
Classe Social	C1 (2.7k a 4.6k)	C1 (2.7k a 4.6k)
PEADia	6.494	12.624

Resumo de Preços

Vision

Nome Fase	Tipologia	Renda	Ato	FGTS	Cond.	Subsídio	PSOL	TCD	VSO	Nom. Pré	Avali.	Elast.	Nom. Pós	Raso Pós	PSOL (m)	RET1
Cuiabinho F2	HIS	2.681	0,89	0,72	97,8%	93,0%	97,2%	71,9%	11	214.763	245.000	3,3333%	221.922	202.481	24	50%
Cuiabinho F2	HIS - Vg Moto	3.199	0,74	0,62	96,9%	112,5%	84,9%	60,6%	6	219.800	251.000	3,3333%	227.127	207.589	24	50%
Cuiabinho F2	HIS - Vg Carro	3.499	0,69	0,65	97,0%	137,8%	85,8%	55,3%	3	232.455	260.000	3,3333%	240.204	220.696	24	25%

Ciclo Financeiro – Análise Mancha

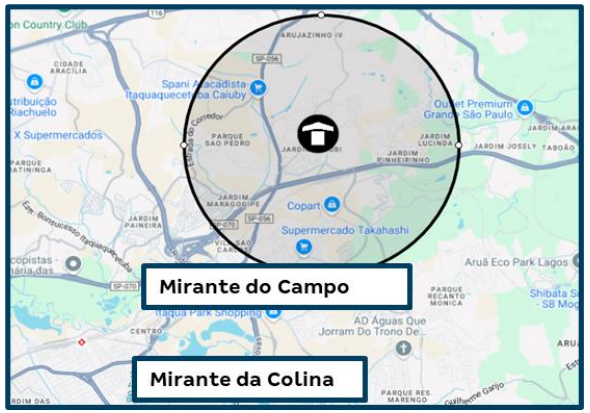

-	Cuiabinho F1					Mirante Da Colina - Com Emcash					Mirante Do Campo - Sem Emcash			
Tipologias	Avaliação	Preço Nominal	CEF	Renda	% Unidades	Avaliação	Preço Nominal	CEF	Renda	Farol	Preço Nominal	CEF	Renda	Farol
HIS	245.000	218.427	171.592	2.681	70%	245.280	229.690	173.778	3.030	●				
HIS - Vg Moto	251.000	223.620	175.613	3.199	1%									
HIS - Vg Carro	260.000	236.675	185.858	3.499	29%	260.000	253.490	188.902	4.050	●	238.323	190.658	4.138	●
Garden | Vg Carro						285.600	266.890	198.029	4.260	–				

Parecer Ciclo

Ciclo avaliou Preço e VSO como factíveis. O projeto está em uma região estratégica na borda de São Paulo, e consolidada com diversos projetos da Tenda. Os concorrentes existentes possuem preços mais altos, não concorrendo diretamente com o nosso público.

Pareceres

Análise da Mancha e Implantação

Prospecção

Operações

Incorporação

Inteligência de Mercado

Financeiro

Anexos

Informações Financeiras

Cuiabinho - SPRM - Região Metropolitana > 100mil SP

Datas e Prazos

	Compra	Lançamento	Início Obra	Término Obra	LÇTO até IO	IO até TO	Chaves	LÇTO até Chaves
Consolidado	out-24							
F1 sem vaga		jun-27	dez-27	nov-29	6 meses	23 meses	jun-30	36 meses
F1 vaga moto		jun-27	dez-27	nov-29	6 meses	23 meses	jun-30	36 meses
F1 vaga carro		jun-27	dez-27	nov-29	6 meses	23 meses	jun-30	36 meses
F2 sem vaga		nov-28	mai-29	dez-30	6 meses	19 meses	nov-31	36 meses
F2 vaga moto		nov-28	mai-29	dez-30	6 meses	19 meses	nov-31	36 meses
F2 vaga carro		nov-28	mai-29	dez-30	6 meses	19 meses	nov-31	36 meses

Terreno e Incorridos

TOTAL (R$ + Perm.):	4,49 MM	**Incorrido Terreno:**	0,00 MM	**Área do Terreno (100%):**	12.500 m²
Cash:	0,00 MM	**Nº de Parcelas Cash :**	0	**Custo de terreno m²:**	358,9
Permuta Financeira:	4,49 MM (1,75%)			**VaR 25 (R$ mil):**	0
Permuta Física:	0,00 MM (0,00%)			**VaR 26 (R$ mil):**	0
Ato / %VGV:	0,00 MM / 0,0%			**Incorrido de Construção:**	0,00 MM

Área Líquida do Terreno:	12.478 m²
Custo de terreno m² Área Líquida:	359,6
Fração Terreno/Terreno + Custo Obra (%VGV):	1,8% / 48,3%
CA Máx/Proj.	3,5 / 3,0
Incorridos de Incorporação:	0,16 MM

Vendas

Fases	Nº Pavimentos	Preço Raso Unit.	Qtde	Preço Unit.	Aval. CEF	Cond. Parcela	% Pró-soluto	% TCD
F1 sem vaga	T+25	199.613	543	218.427	245.000	97,8%	94,0%	69,6%
F1 vaga moto	T+25	204.712	8	223.620	251.000	96,1%	82,2%	58,6%
F1 vaga carro	T+25	217.797	225	236.675	260.000	95,7%	83,0%	53,5%
F2 sem vaga	T+25	202.481	216	221.922	245.000	97,8%	97,2%	71,9%
F2 vaga moto	T+25	207.589	106	227.127	251.000	96,9%	84,9%	60,6%
F2 vaga carro	T+25	220.696	42	240.204	260.000	97,0%	85,8%	55,3%

Unidades Totais:	1.140	**Preço Médio:**	224.338	**Renda Média:**	2.924	**ITBI+Emol. Unit. Médio:**	4.555
Unidades Tenda:	1.140	**Avaliação Média:**	249.113	**Ato:**	2.409 (0,82 Salários)	**Custo do Ciclo Unit.:**	14.124
VSO:	31,5 Unidades	**VGV Total:**	255.745.859	**FGTS:**	2.017 (0,69 Salários)	**Preço Raso Médio:**	205.299
RET Médio:	2,7%	**VGV Tenda:**	255.745.859	**% em RET 1%:**	44%	**Adc. Tx. de Aceleração Médio:**	750

Construção

Custo Total Unit. | Corrigido:	104.482 | 104.967	**Eventuais:**	4,00%	**Área priv (m²):**	32,00	**Gape / Mês Unit.:**	11,08

Resultado

LI (R$):	**33.865.283**	**LI:**	**23,71%**	**Exposição de Caixa (R$):**	**19.604.457**	**Margem Bruta Econômica:**	**42,10%**
TIR:	**135,25%**	**LI Aprovação:**	**20,00%**	**Ger. Caixa 12 meses (R$):**	**0**	**Margem Bruta REF:**	**45,21%**
Exposição de Caixa:	**7,04%**	**Δ LI:**	**3,71%**	**Ger. Caixa 24 meses (R$):**	**(6.872.941)**	**Margem Rasa Econômica:**	**36,03%**
Payback Contingente (21 m):	**20 m/ (-1 m)**	**LI Resiliência:**	**17,67%**	**Ger. Caixa Marginal (R$):**	**80.613.399**	**Margem Rasa REF:**	**40,13%**
Payback Consolidado:	**20 meses**					**Margem de Contribuição Econômica:**	**30,55%**

Informações Financeiras

R$ Mil - Valores Nominais - Compra	Cuiabinho		Primeira Fase		Demais Fases	
	Nominal	%	Nominal	%	Nominal	%
Receita	278.396	100,0%	184.923	100,0%	93.473	100,0%
PIS/COFINS	(4.097)	1,5%	(2.768)	1,5%	(1.329)	1,4%
Custo Total	(158.816)	57,9%	(104.985)	57,6%	(53.831)	58,4%
Custo Terreno	(4.493)	1,6%	(2.985)	1,6%	(1.509)	1,6%
Custo Relacionados a Terreno	(495)	0,2%	(329)	0,2%	(166)	0,2%
Custos de Incorporação	(6.001)	2,2%	(3.984)	2,2%	(2.017)	2,2%
Custo de Construção	(147.828)	53,9%	(97.687)	53,6%	(50.141)	54,4%
Lucro Bruto Econômico	115.483	42,1%	77.170	42,4%	38.313	41,6%
Custo para Rateio	-	0,0%	-	0,0%	-	0,0%
Lucro Bruto Contábil	115.483	42,1%	77.170	42,4%	38.313	41,6%
Despesas de Selling	(25.269)	9,2%	(16.789)	9,2%	(8.480)	9,2%
Contingência	(6.403)	2,3%	(4.253)	2,3%	(2.150)	2,3%
Margem de Contribuição	83.810	30,6%	56.127	30,8%	27.683	30,0%
IR e CSLL	(3.352)	1,2%	(2.265)	1,2%	(1.087)	1,2%
Margem Líquida	80.458	29,3%	53.862	29,6%	26.596	28,9%
Lucro Bruto REF Unit.	113.758	45,2%	111.465	45,4%		
Lucro Raso REF Unit.	92.422	40,1%	90.845	40,4%		

R$ Mil - VPL - Compra	Cuiabinho		Primeira Fase		Demais Fases	
	VP	%	VP	%	VP	%
Receitas	142.815	100,0%	101.661	100,0%	41.154	100,0%
PIS/COFINS	(2.076)	1,5%	(1.500)	1,5%	(577)	1,4%
Custos e Despesas Totais	(106.873)	74,8%	(75.700)	74,5%	(31.173)	75,7%
Custo Terreno	(2.206)	1,5%	(1.570)	1,5%	(636)	1,5%
Custo Relacionados a Terreno	(373)	0,3%	(248)	0,2%	(125)	0,3%
Custos de Incorporação	(3.663)	2,6%	(2.582)	2,5%	(1.081)	2,6%
Custo de Construção	(81.585)	57,1%	(57.648)	56,7%	(23.938)	58,2%
Despesas de Selling	(15.630)	10,9%	(11.215)	11,0%	(4.416)	10,7%
Contingência	(1.717)	1,2%	(1.210)	1,2%	(506)	1,2%
IR e CSLL	(1.699)	1,2%	(1.227)	1,2%	(472)	1,1%
Lucro Imobiliário	33.865	23,7%	24.461	24,1%	9.404	22,9%

Comparativo Comitê Jun/25

Comparativo dos Estudos - Consolidado	Anterior	Atual	Atual vs Anterior	Δ%
Data Estudo:	junho-25	dezembro-25	6 Meses	N/A
Lançamento:	abril-27	junho-27	2 Meses	N/A
Uhs:	499	1.140	641	128,5%
Preço Nominal:	225.244	224.338	(905)	-0,4%
Preço Raso:	203.723	205.299	1.576	0,8%
Preço Nominal Inflacionado:	253.270	251.624	(1.646)	-0,6%
Preço Raso Inflacionado:	229.103	230.288	1.186	0,5%
Renda Média:	3.200	2.924	(275)	-8,6%
RET Médio:	2,88%	2,68%	-0,2 p.p.	-7,0%
% em RET 1%:	37,47%	44,14%	6,7 p.p.	17,8%
VSO:	28	32	4	12,5%
ITBI/Emol. Inf (Unit)[2]:	6.204	5.838	(366)	-5,9%
Avaliação:	225.030	249.113	24.083	10,7%
Prazo construção F1:	20	23	3	15,0%
Prazo de Pró-Soluto F1:	25	28	3	12,0%
Custo Total Inf (Unit):	143.112	139.313	(3.799)	-2,7%
Custo Construção (Unit):	102.308	104.482	2.174	2,1%
Fração de construção:	46%	46,8%	1,1 p.p.	2,5%
INCC Folha Rosto:	1.178,39	1.216,71	38	3,3%
Custo Terreno Inf:	4.524.546	4.493.410	(31.136)	-0,7%
Custo Relacionados a Terreno (Unit):	1.204	434	(770)	-64,0%
Fração do Terreno[1]:	4,0% / 49,4%	1,8% / 48,3%	-2,2 p.p.	-55,0%
Custo de Incorp. por uh:	6.087	5.264	(824)	-13,5%
ITBI/Emol. Inf (Total)[2]:	3.095.727	6.655.162	3.559.435	115,0%
Custo do Ciclo (Unit):	14.179	14.124	(54)	-0,4%
LI Resiliência:	15,6%	17,7%	2,0 p.p.	13,0%
Lucro Imobiliário:	22,1%	23,7%	1,6 p.p.	7,5%
LI Resiliência:	15,6%	17,7%	2,0 p.p.	13,0%
Exposição de caixa:	11,3%	7,0%	-4,2 p.p.	-37,5%
TIR:	131,1%	135,3%	4,2 p.p.	3,2%
Margem Bruta REF:	44,1%	45,2%	1,1 p.p.	2,6%
Margem Bruta Econômica:	40,9%	42,1%	1,2 p.p.	3,0%
Margem Rasa REF:	38,2%	40,1%	2,0 p.p.	5,2%
Margem Rasa Econômica:	33,8%	36,0%	2,2 p.p.	6,5%
Margem Contribuição Econômica:	29,2%	30,6%	1,4 p.p.	4,7%
Payback Contingente (Régua 21 m):	19 m/ (-2 m)	20 m/ (-1 m)	1	
Payback Consolidado:	19 Meses	20 Meses	1 Meses	5,3%

[1] Valor do terreno contratual

[2] ITBI com taxa de Aceleração

Pareceres

Análise da Mancha e Implantação

Prospecção

Operações

Incorporação

Inteligência de Mercado

Financeiro

Anexos

- **DESCRIÇÃO DO IMÓVEL:** terreno urbano situado na Estrada do Cuiabá, Itaquaquecetuba/SP, objeto da matrícula nº 17 do Oficial de Registro de Imóveis de Itaquaquecetuba, com área total de 73.608,25 m², cadastrado sob o contribuinte municipal 44434-32-76-0001-00-000.

- **PROPRIETÁRIA: APEMA – Assessoria e Participações em Empreendimentos Imobiliários Ltda.**, sociedade empresária limitada, com sede na Rua Marconi, nº 53, 12º andar, Salas 121 e 122, Centro, São Paulo/SP, inscrita no CNPJ nº 49.467.137/0001-40, registrada na JUCESP sob o NIRE 35213445050. Representada em Contrato de Compra e Venda, conforme Contrato Social consolidado arquivado em 18/09/2020 (nº 381.363/20-0), por suas sócias-administradoras **Ana Lúcia Guedes de Paiva** e **Cristiane Lebani**, com poderes de administração conjunta, nos termos do referido ato constitutivo.

- **DA CONSULTA AO CADASTRO NACIONAL DE EMPRESAS INIDÔNEAS E SUSPENSAS:** Negativo

- **CONSIDERAÇÕES JURÍDICAS SOBRE DD IMÓVEL**: Conforme a documentação atualizada e certidões emitidas pela Prefeitura Municipal de Itaquaquecetuba em 11/11/2025, o imóvel objeto da matrícula nº 17 do Oficial de Registro de Imóveis de Itaquaquecetuba/SP, localizado na Estrada do Cuiabá, s/nº, encontra-se regular sob os aspectos fiscal e registral, sem débitos pendentes. **(a) Débitos imobiliários:** A Certidão Negativa Imobiliária nº 18811/2025, válida até 11/05/2026, confirma a inexistência de débitos tributários e não tributários vencidos relacionados ao imóvel. Não há registros de inscrições em dívida ativa ou exigibilidade suspensa. **(b) Ônus e gravames:** Não subsistem ônus reais ativos. **(c) Processos judiciais e restrições administrativas:** Até o momento, não há ações judiciais, fiscais ou ambientais com reflexo direto sobre o imóvel, tampouco restrições administrativas incidentes na matrícula. **(d) Cadastral e fiscal:** O cadastro municipal nº 44434-32-76-0001-00-000 encontra-se individualizado e ativo, vinculado à área total de 73.608,25 m². Não há inconsistências cadastrais ou pendências perante a municipalidade. **(e) Ocupação e uso:** O terreno encontra-se desocupado, sem construções ou contratos de locação vigentes, conforme declaração da vendedora constante do Compromisso de Venda e Compra.

- **APEMA – CONSULTORIA E EMPREENDIMENTOS LTDA.: (a) Participação societária:** Sociedade empresária limitada, com sede na cidade de São Paulo/SP, inscrita no CNPJ nº 49.467.137/0001-40, registrada na JUCESP sob o NIRE 35213445050, tendo como sócias-administradoras Ana Lúcia Guedes de Paiva e Cristiane Lebani, ambas com poderes de administração conjunta, conforme Contrato Social consolidado arquivado em 18/09/2020 (nº 381.363/20-0). **(b) Regularidade fiscal e municipal:** A empresa mantém inscrição municipal ativa perante a Prefeitura de Itaquaquecetuba/SP, e não há registros de débitos tributários ou fiscais em aberto. As informações disponíveis indicam situação fiscal regular perante os órgãos municipais e federais competentes. **(c) CND Federal:** Consta certidão conjunta da Receita Federal e PGFN com efeitos de negativa, confirmando a inexistência de débitos relativos a tributos federais e dívida ativa da União.

- **(d) Ações cíveis:** Foram identificadas três ações cíveis em trâmite perante o TJSP, todas classificadas como de baixo impacto. Dentre elas, uma execução fiscal municipal para cobrança de IPTU referente a outro imóvel situado em Itaquaquecetuba/SP, no valor atualizado de R$ 747.281,79, e duas demandas de menor valor, todas sem reflexo direto sobre a presente transação.

- **CONCLUSÃO.:** Com base na *Due Diligence* Jurídica realizada até novembro de 2025, verifica-se que o imóvel objeto da matrícula nº 17 do Oficial de Registro de Imóveis de Itaquaquecetuba/SP não apresenta óbices jurídicos ou fiscais capazes de impedir ou colocar em risco a aquisição pretendida. As certidões fiscais e imobiliárias atestam a inexistência de débitos tributários ou não tributários, e as ações judiciais em nome da proprietária (APEMA) possuem impacto reduzido, sem reflexos sobre o imóvel objeto da transação.

LEGALIZAÇÃO E DPP

➢ ÁREA DE IMPLANTAÇÃO

- O terreno é composto por 1 matrícula de nº 17 (1 ORI), em nome de pessoa jurídica (APEMA), totalizando área escriturária de 73.608,25 m² e real 69.122,20m² – diferença de área se encontra no terreno remanescente do vendedor;
- O cadastro do imóvel é urbano.

➢ DIRETRIZ URBANÍSTICA

- A LUOPS foi aprovada em 02/12/25. A nova Diretriz Urbanística foi solicitada de imediato, porém, em razão da recente aprovação da lei, a Prefeitura ainda não retomou a emissão do documento. Os sistemas internos estão em atualização, com previsão de cerca de 30 dias para normalização. Segundo a equipe técnica, a emissão deverá ocorrer em prazo superior ao habitual, com expectativa de disponibilização no início de 2026.
- A aprovação de empreendimentos com unidades HIS ou HMP está condicionada a emissão de um Relatório de Diagnóstico de Demanda Habitacional, elaborado pelo corpo técnico da Prefeitura, e que concluirá pela viabilidade ou inviabilidade habitacional do empreendimento.

➢ ÓRGÃOS DE PATRIMÔNIO HISTÓRICO

- Municipal: Não apresentado.
- Estadual – Condephaat: Não apresentado.
- Federal – IPHAN: Não apresentado.

➢ DRENAGEM

- Lançamento da drenagem no Córrego Cuiabá. Será necessária aprovação na CETESB por se tratar de trecho em APP;
- Desenvolvido estudo hidrogeológico para identificar existência de corpos d’água dentro do terreno;
- Desenvolvido estudo hidrológico prevendo cota de inundação próximo ao córrego 749,269 e no canal de drenagem 749,775.

LEGALIZAÇÃO E DPP

➢ AVALIAÇÕES AMBIENTAIS

Arbóreo

- A propriedade não está inserida em Área de Patrimônio Ambiental (APA), Área de Proteção de Mananciais (APRM) e Unidade de Conservação;
- Incide sobre o Terreno Fragmento Florestal em estágio inicial de regeneração natural;
- Pelo cadastramento arbóreo constam 650 indivíduos isolados, sendo 639 exemplares se encontram no interior do imóvel e 11 exemplares na calçada;

Destes, 465 indivíduos são de origem nativa e 117 são de origem exótica e 68 exemplares mortos ou cadastrados como tocos;

- Nenhum dos exemplares encontrados está na ameaçado de extinção;
- Há a possibilidade de descaracterização de APP por anterioridade (uso agrícola). Temos laudo da REGEA favorável para protocolo na CETESB.

Hidrografia

- O Imóvel apresenta o Córrego Cuiabá nos fundos.
- Os corpos d'água internos ao perímetro ou próximo foram caracterizados como drenagem nos estudos realizados;
- Córrego mais próximo do imóvel, sendo este o Córrego Cuiabá.

Contaminação

- Existência de PV de esgoto da SABESP lindeiro ao imóvel;
- Ocupação anterior da área é de plantações agrícolas (possível fonte de contaminação);
- O Estudo Preliminar foi finalizado indicando a necessidade de continuação para a Análise Confirmatória em razão dos 02 pontos acima;
- A Confirmatória está sendo realizada por exigência aplicável a áreas com uso agrícola; porém, a consultoria contratada considera improvável a existência de contaminação, dado o porte reduzido da plantação.

➢ MOVIMENTAÇÃO DE TERRA

- Entender a necessidade de aprovação de projeto de movimentação de terra junto ao município.

LEGALIZAÇÃO E DPP

- **ABASTECIMENTO SANITÁRIO**

- Diretrizes SABESP 187/24, emitida em 08/11/24 para 499 UH. Será necessária nova diretriz em razão do aumento do número de unidades.
  - Esgoto - não consideramos ETE pois foi verificado que as obras do contrato 00.249/24 estão previstas para finalizar ainda em 2025, com ligação especial na rede cadastrada a Estrada do Cuiabá;
  - FNA conforme identificado na diretriz de SABESP sobre rede de esgoto existente - na área remanescente do proprietário;
  - Água – ligação especial de água (derivação e VRP) considerando a interligação na rede existente na estrada do Cuiabá com diâmetro de 200mm na testada do lote.

- **GRAPROHAB**

- Haverá necessidade de análise do corpo técnico em razão do número de unidades (acima de 800 uhs).

- **URBANIZAÇÃO**

- Aguardar emissão de diretriz urbanística para entender a necessidade de melhoramento viário.

- **CONTRAPARTIDA**

- Haverá cobrança de medida mitigadora por meio de aprovação de EIV. Em conversa com Secretário, considerar 930 mil reais.

- **COMAER**

- Não apresentado.

- **OUTROS ITENS NECESSÁRIOS/ESPECÍFICOS**

- Será necessário projeto de desmembramento;
- Logística solicita que seja obtida autorização para utilização do viário.

CRONOGRAMA PRÉVIO

Cuiabinho	dez/25	jan/26	fev/26	mar/26	abr/26	mai/26	jun/26	jul/26	ago/26	set/26	out/26	nov/26	dez/26	jan/27	fev/27	mar/27	abr/27	mai/27	jun/27
	1	2	3	4	5	6	7	8	9	10	11	12	13	14	15	16	17	18	19
PROSPEC - Comitê Essencial																			
PROSPEC - Comitê Ampliado (Condicionado à Nova Legislação Aprovada)																			
PROSPEC LEG DPP - Baixa LB / Reunião de Passagem																			
LEG - COMAER																			
LEG - Emissão lei com liberação do HIS para R4																			
LEG - Certidão de Uso do Solo																			
LEG - Diretriz Urbanística + Habitação (RDD)																			
LEG - Manifesto Ambiental																			
LINHA - PRE-KIT AP																			
LEG - Definição poligonal																			
LEG - PL e memo desmembramento																			
LEG - Desmembramento*																			
JUR - Registro desmembramento*																			
LINHA - Elaboração PL																			
LEG - NBR																			
LEG - Aprovação Drenagem (Verificar sobre projeto complementar)																			
LEG - Aprovação movimentação de terra (Verificar sobre projeto complementar)																			
LEG - Aprovação supressão vegetação																			
NEG - Carta de enquadramento CEF																			
LEG - EIV																			
LEG - Alvara de aprovação e execução																			
LEG - Cadastro de Habitação - preferencia lista da prefeitura																			
LEG - Certidão de Conformidade																			
LEG - Análise GRAPROHAB																			
JUR - Escritura e RI																			
CRE - Contratação CEF																			
NEG - Lançamento																			

Postergação em função do predecessor

Limite do predecessor

* Caminho crítico

Obrigado