Tenda

sua próxima conquista

Book Essencial de Investimento

Regional: SP – Zona Norte

Projeto: Pedro de Castilho (PROTENDIT)

Data Comitê: 08/12/2025

One Page – Pedro de Castilho

Cidade	São Paulo	**Mancha de demanda**	SP - SZN2 - São Paulo Norte 2
Regional	SP	**Cluster MPR**	1 - Vermelho
Cenário de Aprovação	Aprovação	**Tipo de Aprovação**	Consolidado
Fase Anterior	N/A		
Tipo de Comitê	Essencial	**Versão da VF**	Versão 1.0: Dez

Unidades (Fases)	952 (1)	**CA Máx | Proj**	4,0 | 2,8
Unidades com Vaga (%)	0 (0%)	**Escritura | Lançamento**	set/27 | nov/27
Unidades com Varandas (%)	0 (0%)	**Tipologia**	F2E - Concreto

Valor Líquido do Terreno (% VGV)	20.661 (9,9%)	**Un. Perm. Fís (% Ter)**	0 (0,0%)
Cash (Correção)	0 (N/A)	**%VGV Perm Fin Líquida (% Ter)**	9,9% (100,0%)
Valor R$/m²	2.086	**VAR (%VGV)**	000 (0,0%)

Custo Construção (%VGV)	93.190 (44,7%)	**Indireto Unit.**	17.206
Prazo da Obra (meses)	25	**Torre Unit.**	54.071
Custo Total Unit. | Corrigido (LPU):	97.888 | 98.343 (94)	**Infra Unit.**	13.045
Início de Obra	mai-28	**Fundação Unit.**	9.038

Preço Nominal Unit.	219.216	**VSO**	53
Preço Raso Unit.	197.616	**Referência**	Vision
Avaliação Unit.	230.000	**Renda (% em RET 1%)**	2.573 (75,0%)

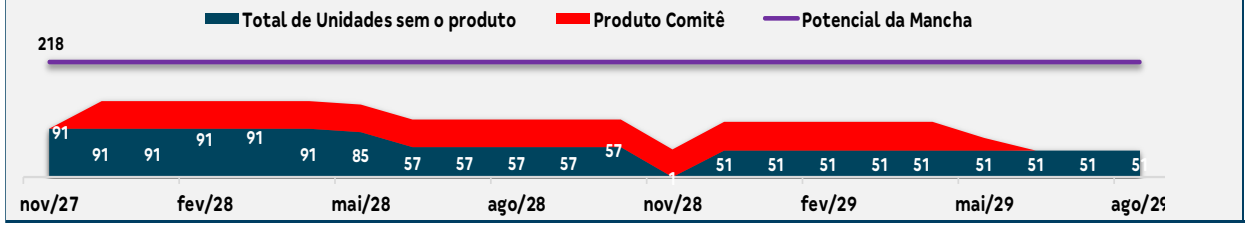

LI (Régua):	**20,1% (20,0%)**	**Margem Bruta Econômica:**	36,0%
LI Resiliência:	13,3% (N/A)	**Margem Rasa Econômica:**	28,0%
Margem Bruta REF:	38,8%	**Margem Contribuição Econômica:**	25,4%
Margem Rasa REF:	**32,2%**	**Exposição (% VGV):**	15.303 (6,7%)
TIR:	168,3%	**VGV Total:**	**208.694**
Payback Contingente (21 m) :	**19 m/ (-2 m)**	**Ger. Caixa 12 meses (R$):**	-
Payback Consolidado:	19	**Ger. Caixa 24 meses (R$):**	(2.030)

Destaques

[1] O Terreno está localizado na Rua Pedro de Castilho – Tremembé, mancha ZN2 - Zona Norte de São Paulo, com fácil acesso a Rodovia Fernão Dias. Terreno com gabarito T+9, área de matrícula de 20.000 m² e área liquida 11.003m², zoneamento ZPI 2, gabarito de 28m.

[2] O projeto aqui proposto para compra é composto por 1 condomínio e um total de 952uh e VGV 207MM. CA do projeto está em 2,77x (68%) da área líquida, de um CA máx permitido de 4,05X; não estamos considerando por enquanto % de varanda - será estudado posteriormente. Projeto em comitê assumindo a nova proposta técnica de geminação de torres – até termos uma confirmação dos custos da solução técnica, estamos assumindo acréscimo de 1K/unidade no custo de construção da folha rosto diretamente na viabilidade;

[3] Condição Comercial: Permuta Financeira
- 100% Permuta Financeira: 11% de permuta bruta com desconto de 10%, resultando em uma permuta líquida de 9,9%. Estimativa na viabilidade de 22,86MM na permuta Bruta e 20,6MM na permuta líquida;
- Mínimo Garantido R$ 15.575.961,44, sem condição de correção e com prazo de pagamento do PMG de 12 meses após habite-se;

OBS: Preço do terreno: R$ 687/CA e R$ 1.870/m2 terreno (ref. base valor terreno sobre a permuta liquida (20,6MM) e área liquida (11mil m2))

[4] Condições de descontos Contratuais
a) Despesas decorrentes da necessidade de intervenção/contenção nos taludes existes, serão integralmente descontados do preço do terreno – em fase de estudo (vide slide 18);
b) Despesas de remediação/descontaminação do imóvel serão descontadas do preço do terreno;
c) Despesas para execução da infra estrutura será descontado do preço do terreno caso o valor orçado ultrapasse 1 MM (vide racional slide 16)

[5] Preço de venda:
a) Terreno em região de borda, considerado preço raso baixo de R$197/unid, com enquadramento 75% faixa 1 com renda de 2,5K, para fazer frente a proposta de VSO de 53.

[6] Projeto para aprovação no formato de **Comitê Essencial**, na régua de 20% de LI e baixa de 70% das unidades; temos expectativa de trazermos para comitê Ampliado no 1S26**.**

Pareceres

Análise da Mancha e Implantação

Prospecção

Operações

Incorporação

Inteligência de Mercado

Financeiro

Anexos

Pareceres

Área	Riscos Associados	Parecer	Flag
Jurídico Aquisição	A aquisição envolve 4 (quatro) imóveis.O imóvel denominado no contrato como “Imóvel 1” – MATRÍCULA Nº 43.192, será objeto da primeira fase do empreendimento, o qual possui alienação fiduciário que deverá ser cancelada pela VENDEDORA. Nada foi identificado que desabone os PROPRIETÁRIOS. Os Imóveis 2,3 e 4 possuem débitos de IPTU em valor total global de R$ 3.836.220,27. Os PROPRIETÁRIOS ocupam os imóveis 2, 3 e 4 em uso próprio, e se responsabilizam pelos tramites de desocupação e desmobilização conforme termos contratuais para demais fases contratuais. A princípio, não há elementos que coloquem em risco a presente transação.	Ok com ressalvas	
Legalização	Necessidade de avaliação jurídica com relação a diferença entre a área Real (planialtimétrico) X Escritura.	Ok	
DPP	N/A	Ok	
Inteligência de Mercado	Preço Vision como factível	Ok	
Prospecção	Contrato assinado contemplando a aquisição de 4 imóveis (55.000m²), no qual serão divididos em 2 condomínios, com potencial de aprox. 2.700uh. Neste momento, estamos realizando apenas a baixa do condomínio 1 com 952uh, sendo o condomínio 2 uma “opcionalidade” da Tenda, podendo optar pela compra quando alcançado 90% das vendas do Condomínio 1, porém não há penalidade caso a Tenda desista de seguir com a aquisição, a seu exclusivo critério e a qualquer tempo.	Ok	
Estudos Econômicos	N/A	Ok	
Comercial/Ciclo	Preço e VSO são viáveis	Ok	

Pareceres

Análise da Mancha e Implantação

Prospecção

Operações

Incorporação

Inteligência de Mercado

Financeiro

Anexos

Localização – Rua Pedro de Castilho – Tremembé – São Paulo - SP

Parque da Cantareira

E. E. Prof Philomena Baylao

X Supermercados

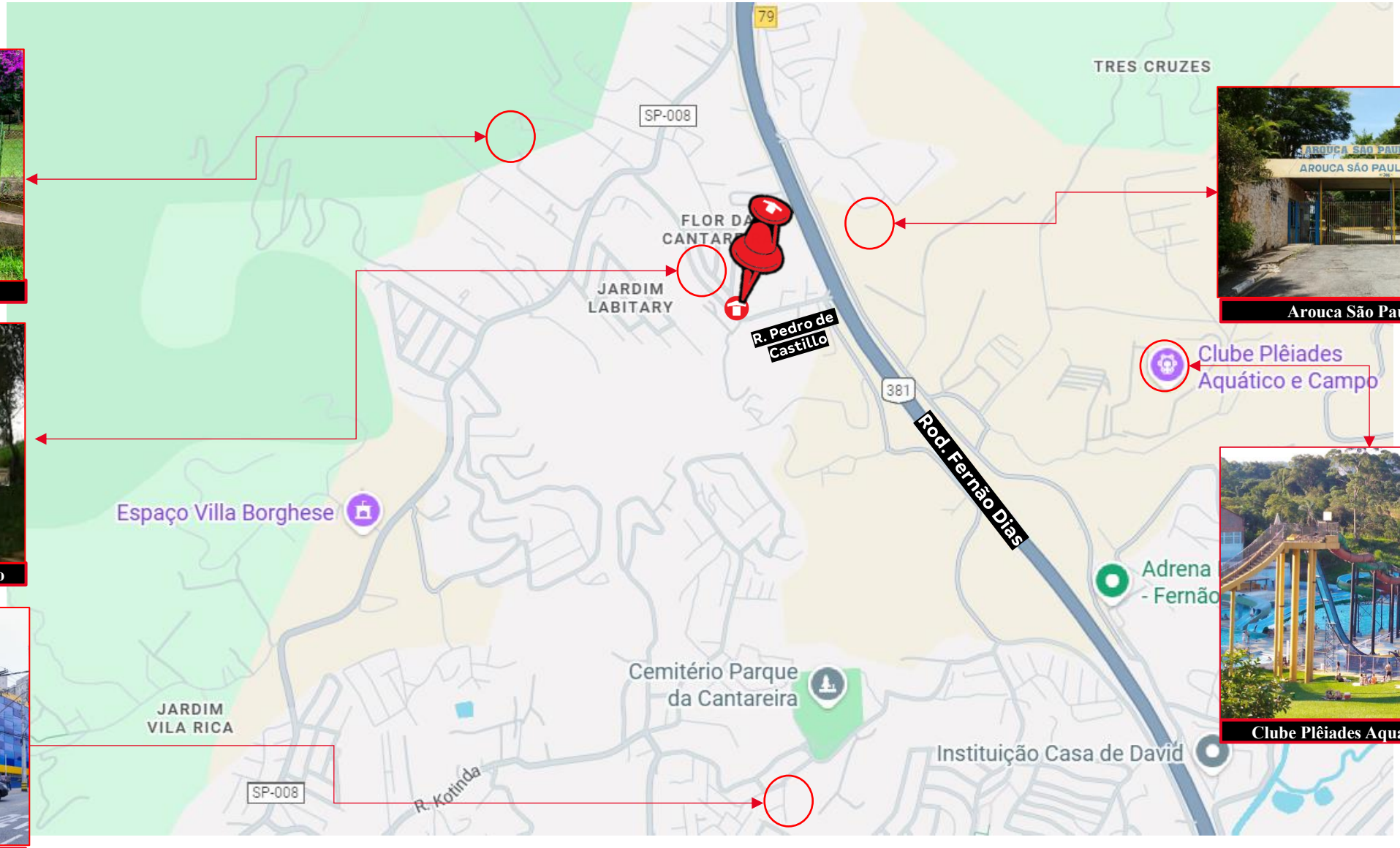

Arouca São Paulo Clube



Clube Plêiades Aquático e Campo

Localização – Rua Pedro de Castilho – Tremembé – São Paulo - SP

Localização – Rua Pedro de Castilho – Tremembé – São Paulo - SP

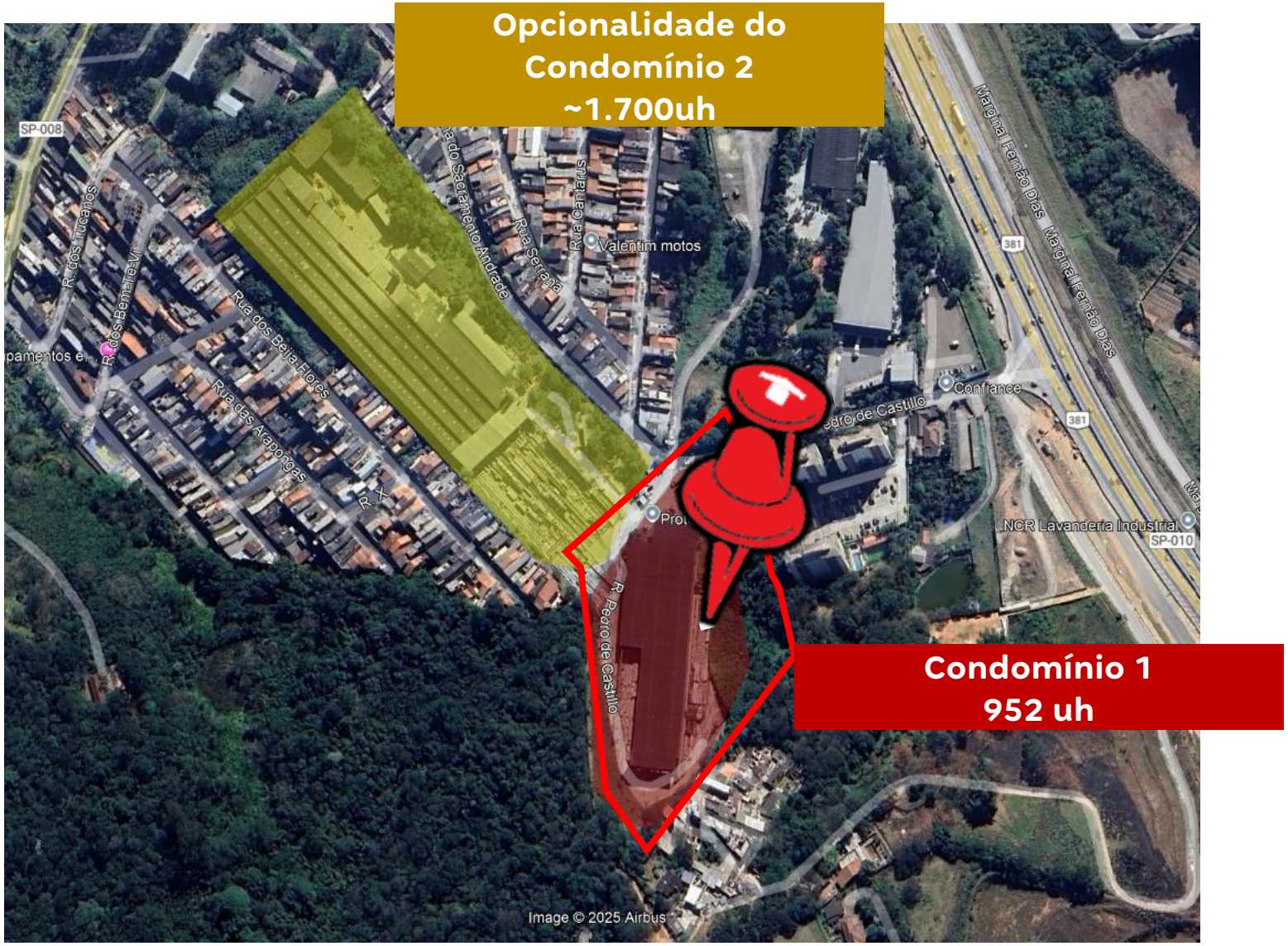

Mancha de Demanda

MANCHAS DE DEMANDA
- SZN – São Paulo Norte

Lançamento
1. Viva City Jaraguá
2. Viva Limão | Parque Limão
3. Melodia Jaçanã
4. Farol Cantareira

LandBank
5. Spazzio Primavera
6. Horizonte Jaraguá
7. Chácara Pirituba
8. Nilo Cairo
9. Bela Vista Jaraguá
10. Reserva Jaraguá
11. Monte Trindade
12. Pedro de Castilho

Cluster MPR – (Comitê)

Cluster 1 - Vermelho

Região

Borda

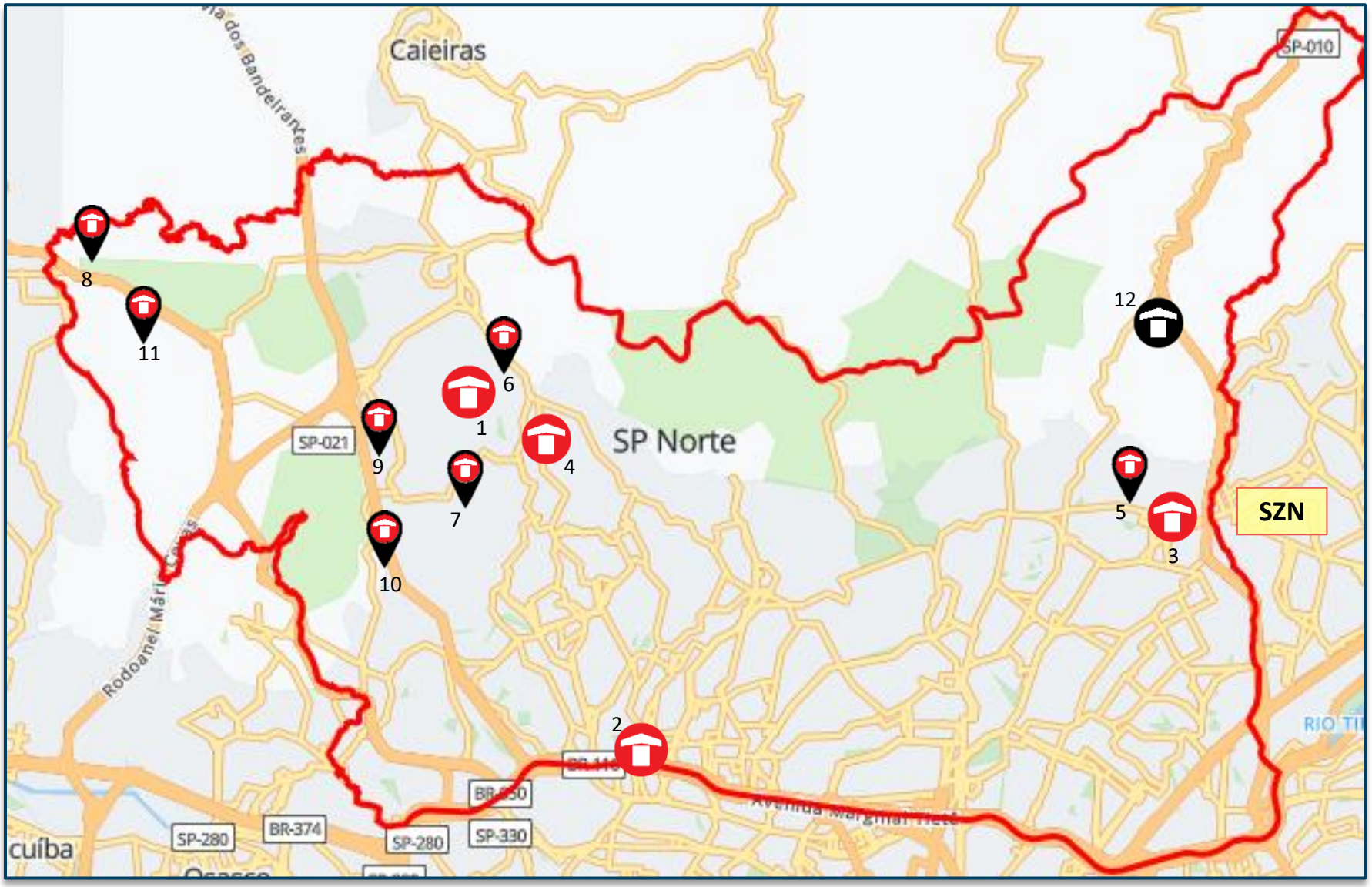

Lançados *LandBank* *Comitê*

PRODUTO

Pedro de Castilho – Comitê Essencial

Informações Gerais – Dois Condominios			
Terreno	Área terreno	21.249,74m²	
	Reserva de calçada / APP	574,45m² | 4.163,75m²	
	Menor poligonal	16.511,54 m²	
	Área liquida	11.003,65 m²	
	Zoneamento	ZPI-2	
	CA máximo	4,05	ZONA: 2,25
			INCENTIVO HIS: 1,125
			COTA: 0,675
	CA Projetado	1,42	
	CA Líquido	2,74	
	Gabarito máximo	T+9	
Geral	Total UH	952	
	Total de vagas	02 (1x PCD/CD)	
Tipologia	Tipologia	V0200	
	Gabarito	T+9	
	Lâmina	12PP | 14PP | 16PP | 20PP | 22PP	
	Área privativa	31,84m² | 33,59m²	
Condomínio	Unidade PCD	27	
	Unidade lazer | técnica	02 | 06	
	Fase	Fase única	
Lazer	Lazer coberto	Salão de Festas Gourmet + Churrasqueira + Brinquedoteca + espaço office	
	Lazer descoberto projetado	play kids, play baby, pet place, fitness	

LEGENDA:

- Área técnica
- Lazer

01 APP de Declividade

02 Área de taludes existente

03 Reserv. De Calçada

ESTUDO DE MASSA

PRODUTO

Pedro de Castilho – Comitê Essencial

	Descrição	Criticidade	Parecer
Usabilidade	**Acesso Empreendimento**	🟢	
	Percurso do pedestre até torre	🟡	Desnível de cerca de 5,00m do acesso da rua até a torre, sendo 2,00m vencidos por rampa/escada até a portaria + 3,00m por elevador.
Diferencial produto	**Prime**	Não	
	Supercondomínio	Não	
	Atributos Infra	-	A definir
	Atributos Torre	-	A definir
	Edifício Garagem	Não	

	Considerações	Criticidade	Descrição
Material analisado	KMZ	🟢	
	Matrícula	🟢	Recebido;
	Planialtimétrico	🟢	Topografia complexa, a principio não estamos considerando custo caso seja necessário retaludamento. Necessário laudo de estabilidade.
Projeto	Área líquida	🟡	Necessário validar a poligonal do projeto
	Drenagem	🟢	

Pareceres

Análise da Mancha e Implantação

Prospecção

Operações

Incorporação

Inteligência de Mercado

Financeiro

Anexos

Condições do Negócio

- **PAGAMENTO DO TERRENO**

- Forma de pagamento:100% permuta financeira.
- Valor do negócio (VF): R$ 22,86MM na permuta bruta e 20,6MM na permuta liquida;
- Valor do negócio (contrato, escritura e preço mínimo garantido): R$ 15.575.961,44. O valor corresponde à estimativa inicial de repasses ao vendedor. Durante a negociação, obtivemos um acréscimo de UH, resultando em repasses superiores aos inicialmente formalizados.
- Permuta Financeira:11% de permuta bruta, com desconto de 10% para despesas com *selling*, marketing e impostos, resultando em uma permuta líquida de **9,9% do VGV** ; com mínimo garantido, sem correção e prazo de quitação do PMG de até 12 meses do habite-se. Caso não tenha atingido o PMG no respectivo prazo acima, ficará a critério dos vendedores aguardar o término do prazo de recebimento ou receber o PMG e dar quitação.
- Não incidirá qualquer forma de correção ou reajuste sobre o valor acordado;

Preço do terreno: R$ 687/CA e R$ 1.870/m2 de terreno (ref. base valor terreno sobre a permuta liquida (20,6MM) e área liquida (11mil m2))

- **ANTECIPAÇÃO DE DESPESAS**
- Não há previsão para antecipação;

- **GARANTIAS**

Para o Vendedor:

- N/A. Em caso de balanço da TENDA negativo, ficará a critério dos vendedores a contratação de um seguro permuta. Nessa hipótese, o valor do seguro será descontado da participação dos vendedores
- Data da escritura prevista: **Setembro / 2027**

- **CORRETAGEM / INTERMEDIAÇÃO IMOBILIÁRIA**
- Sem corretagem. Todas as tratativas foram conduzidas diretamente entre o proprietário e a Tenda;

Condições do Negócio

- **PRAZOS CONTRATUAIS RESOLUTIVAS**
- Etapa I: Prazo 120 dias para resolutivas técnica, jurídica e financeira;
- Etapa II: Em até 24 meses após superação da Etapa I para aprovação do projeto, obtenção do financiamento CEF. viabilidade técnica e financeira, e outorga da ECV;

A critério da TENDA, podemos suspender os prazos contratuais pelo prazo máximo de 9 meses para superação de qualquer das condições resolutivas;

- **PRAZOS CONTRATUAIS – EMPREENDIMENTO**
- Prazo de conclusão das obras: 36 meses + 6 meses de carência
- Prazo de lançamento 1º Condomínio: Após outorga da escritura e respeitado o prazo de resolutivas

- **CONDIÇÕES RESOLUTIVAS / DISTRATO**
- O CVC prevê cláusulas resolutivas específicas, que asseguram à Tenda o direito de rescindir o contrato a seu único e exclusivo critério: como inviabilidades técnicas e financeira do empreendimento

- **INFORMAÇÕES ADICIONAIS**
- Contrato assinado contemplando a aquisição de 4 imóveis (55.000m²), no qual serão divididos em 2 condomínios, com potencial de aprox. 2.700uh. Neste momento, estamos realizando apenas a baixa do condomínio 1 com 952uh, sendo o condomínio 2 uma “opcionalidade” da Tenda, podendo optar pela compra quando alcançado 90% das vendas do Condomínio 1, porém não há penalidade caso a Tenda desista de seguir com a aquisição, a seu exclusivo critério e a qualquer tempo.
- O imóvel será entregue livre e desimpedido, e atualmente está ocupado pela empresa proprietária;
- A demolição e a desmobilização da estrutura pré moldada existente será de inteira responsabilidade dos vendedores. Exceção ao piso de concreto que será demolido pela Tenda (verba prevista em VF equivalente a 750k).
- Eventuais custos decorrentes de intervenções geotécnicas a serem realizadas nos taludes, serão executadas pela TENDA e o respectivo valor será descontado sobre as parcelas vincendas e deduzido do valor do PMG;
- O Imóvel é urbano e possui IPTU.
- Não há condições especificas no contrato que possam acarretar prejuízo na viabilidade.

Pareceres

Análise da Mancha e Implantação

Prospecção

Operações

Incorporação

Inteligência de Mercado

Financeiro

Anexos

Custo de Construção – PREMISSAS

PARÂMETROS					Versão:	set-25 R00
Empreendimento:	Rua Pedro de Castilho - PROTENDIT				INCC base:	1.216,71
Produto / Selo:	F2E Modular	Contenção:	Nível 2		Prazo pré forma:	5,4
Pavimentos Médio:	10	Terraplenagem:	Nível 4		Prazo forma:	9,9
Torres:	6	Varanda %:	0%		Prazo pós Forma:	9,0
PPs médio:	16,0	Piscina:	Não		Prazo total:	25,0
Unidades Construídas:	960	ETE:	Não		EEE:	Não

Infra Externa

Viário (m):	500	Extensão Esgoto (m):	50
Drenagem (m):	0	Extensão Água (m):	500

Custo de Construção – SIMULADOR

ESTIMATIVA

DADOS DA OBRA		BASES		PRAZOS DE OBRA	
Regional:	SP	Data:	dezembro-25	Pré Forma:	5,4 meses
Endereço:		Revisão:	R00	Estrutura:	9,9 meses
Total de UH:	**960**	LPU:	LPU 94	Pós Forma:	9,0 meses
Total Torres:	6	LVS:	agosto-25	**TOTAL:**	**25,0 meses**
Produtos:	F2E Modular	INCC:	1.216,706		
Tipologia:	MODULAR 10PP/16PP T+15			Jogos de Formas:	2
				Takt:	2+2

CUSTOS DE CONSTRUÇÃO

	CUSTO	R$ / UND
CUSTO TOTAL I	**R$ 91.046.406**	**R$ 95.838**
INDIRETO	R$ 16.345.327	R$ 17.206
TORRE	R$ 51.367.824	R$ 54.071
INFRA	R$ 12.393.206	R$ 13.045
FUNDAÇÃO	R$ 8.585.665	R$ 9.038
ETE	R$ 0	R$ 0
EEE	R$ 0	R$ 0
CONTENÇÃO	R$ 172.505	R$ 182
TERRAPLENAGEM	R$ 2.181.878	R$ 2.297
CUSTO TOTAL II	**R$ 2.402.775**	**R$ 2.529**
VIÁRIO	R$ 860.088	R$ 905
DRENAGEM	R$ 0	R$ 0
EXTENSÃO ELÉTRICA	R$ 103.252	R$ 109
EXTENSÃO HIDRÁULICA	R$ 1.439.435	R$ 1.515
CUSTO TOTAL I + II	**R$ 93.449.181**	**R$ 98.368**
CUSTO TOTAL III	**R$ 0**	**R$ 0**
INCORRIDOS NÃO APROVEITADOS	R$ 0	R$ 0
CUSTO TOTAL I A III	**R$ 93.449.181**	**R$ 98.368**
CUSTO TOTAL I A IV	**R$ 93.449.181**	**R$ 98.368**

a. Foi negociado em ctr que a Tenda arca com até R$1MM para obras de infra equivalente R$ 1.050/unid, logo considerando o custo baseado na diretriz estimado em R$ 2.529/unid (hidráulica + recomposição de viário), deduzimos do custo na VF R$ 1.479/unid;
b. Além disto adotamos em função da geminação entre torres um custo estimado de R$ 1k/unid para a solução;
***** Estas duas premissas (dedução de a. e acréscimo de b.) geraram um custo na viabilidade de R$ 97.888.**

OBSERVAÇÕES GERAIS

Parâmetro terraplenagem: Nível 4
Parâmetro Contenção: Nível 2

RATEIO FASEAMENTO

% de Varanda: 0%
Possui Piscina: Não
ETE: Não
EEE: Não

Extensão água e esgoto – Diretriz Sabesp

DIRETRIZ SABESP – EMITIDA EM NOV/25 para 2.450uh

- Extensão de rede de água. Considerado aproximadamente 500m
- Extensão de rede de esgoto. Considerado ligação em frente ao terreno

Obs: Adotamos como medida conservadora na elaboração de custo do condomínio 1, o custo total estimado para uma diretriz de 2.450unid, porém adotando o rateio integral pelo condomínio 1 de 952 unid.

Conclusão

Após análise das seções do talude, observou-se que no trecho mais íngreme (seção A-A), o FS está bem abaixo do recomendado pela norma, apresentando um valor de 1,12, enquanto o mínimo aceitável é de 1,5. Em contrapartida, a Seção B-B, embora abaixo do recomendado (Fs = 1,4), está em uma condição próxima ao limite seguro, indicando que uma análise mais refinada pode melhorar a condição.

Por outro lado, a Seção C-C (Fs = 1,5) demonstrou um fator de segurança aceitável.
Dessa forma, recomenda-se a alocação de verba para estabilização do talude especificamente no trecho mais íngreme, que abrange a seção A- A, enquanto as demais seções não requerem intervenções imediatas. E sim análises mais elaboradas, com realização de ensaios específicos.
Para a seção A-A pode- se verificar a possibilidade de retaludamento para elevar o Fs ou execução de solo grampeado.

Recomendações

Realizar a confirmação dos parâmetros geotécnicos por meio de ensaios específicos, recomenda – se ensaio de cisalhamento direto.
Efetuar mais seções de cálculo, mapeando todo o talude, entendendo a abrangência das seções.

Dimensionamento prévio: Projeção da seção A-A - Extensão = 58,0m
Solo grampeado - 7 grampos com 10,0m de comprimento e 7 grampos com 8,0m de comprimento - malha 1,5m x 1,5m totalizando 14 grampos por seção.
Concreto projetado espessura 10cm com tela Q181
Instalação de barbacãs - malha em zig zag 3,0m x 3,0m

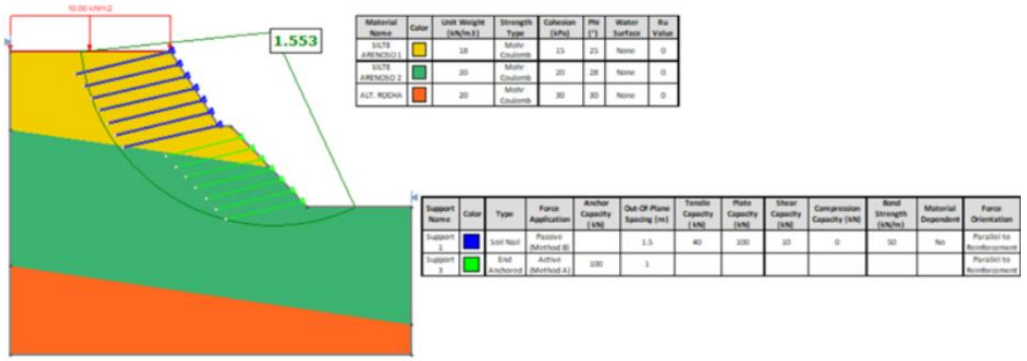

Material Name	Color	Unit Weight (kN/m3)	Strength Type	Cohesion (kPa)	Phi (°)	Water Surface	Ru Value
SILTE ARENOSO 1		18	Mohr Coulomb	15	25	None	0
SILTE ARENOSO 2		20	Mohr Coulomb	20	28	None	0
ALT. RODHA		20	Mohr Coulomb	30	30	None	0

Support Name	Color	Type	Force Application	Anchor Capacity (kN)	Out-Of-Plane Spacing (m)	Tensile Capacity (kN)	Plate Capacity (kN)	Shear Capacity (kN)	Compression Capacity (kN)	Bond Strength (kN/m)	Material Dependent	Force Orientation
Support 1		Soil Nail	Passive (Method B)		1.5	40	100	10	0	50	No	Parallel to Reinforcement
Support 3		End Anchored	Active (Method A)	100	1							Parallel to Reinforcement

Avaliação Taludes – Especialista Fundação TENDA

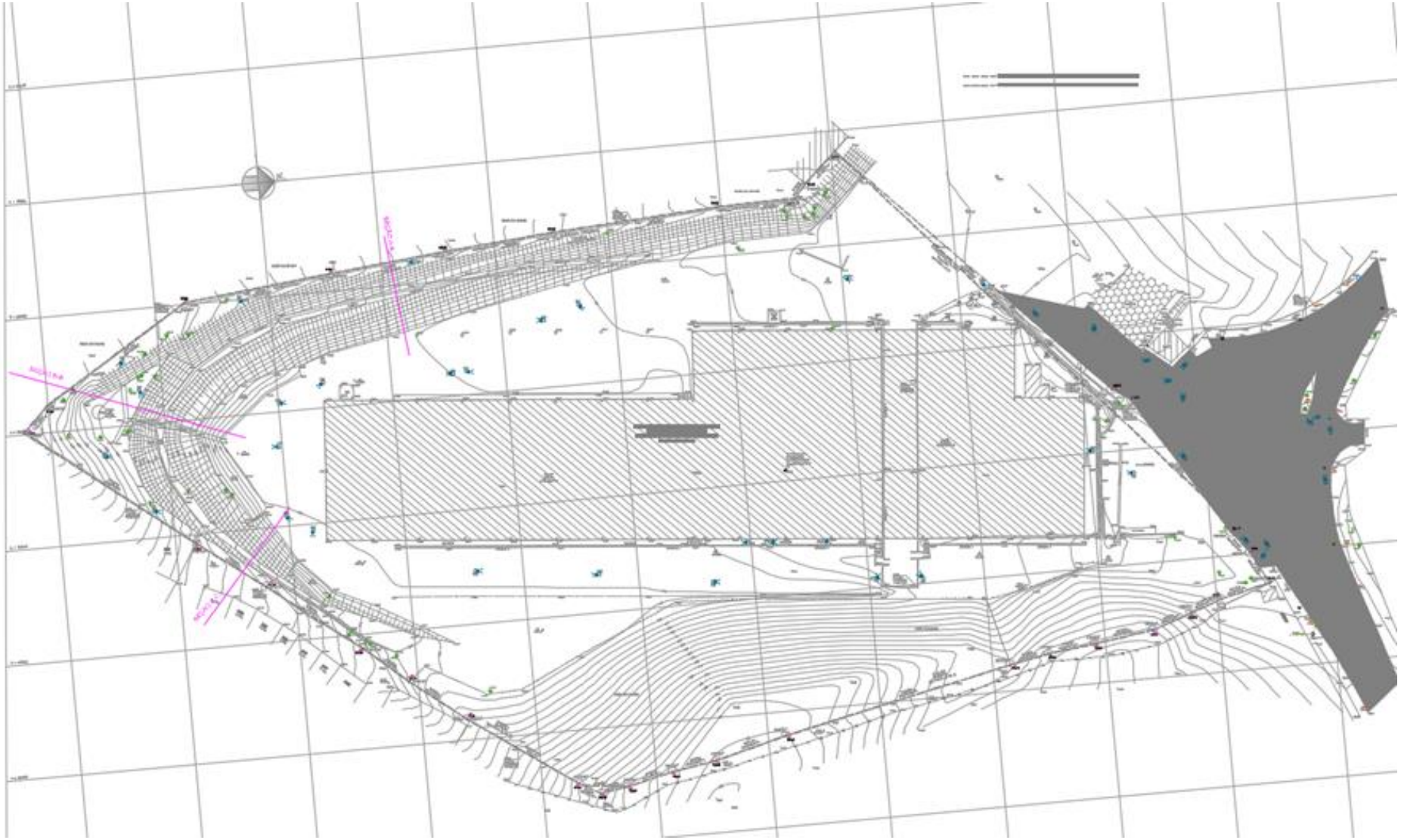

Pareceres

Análise da Mancha e Implantação

Prospecção

Operações

Incorporação

Inteligência de Mercado

Financeiro

Anexos

AMBIENTAL + LEGALIZAÇÃO – Paramétrico de custos

REGIONAL SP

PARAMÉTRICO DE CUSTOS LEGALIZAÇÃO

DADOS		QUANDO APLICAR
Quantidade de unidades	952	
O Empreendimento terá R2V?	NÃO	
Qual a área do Terreno?	20.000	
Quanto % do terreno Possui árvore?	0%	Se possivel contas arvores, considerar 6m² X quantidade de arvores / area do terreno. Caso não seja possivel, estimar por poligonal
Possível Área Contaminada?	SIM	Terrenos com histórico de uso industrial anterior; Os vizinhos do entorno podem possuem uso geradores de contaminantes (posto de gasolina, fabricas, gasodutos, etc...);
Esta Cadastrado como Área Possivelmente Contaminada nos Orgão Publicos?	NÃO	Quando no GEOSAMPA estiver classificado como área possivelmente contaminada
Parcelamento do Solo?	NÃO	
Quantos Condomínios?	1	Incluir a quantidade de condomínios que serão gerados no licenciamento

ABERTURA	$ FINAL	MÉTRICA
Compensação Ambiental	R$ -	média histórica/ m² de terreno + acrescimo de 30% do valor com aplicação de R2V
Laudos, EIV, EIARIMA	R$ 15.000	15k fixo
Emolumentos e Taxas	R$ 35.000	5k - Revalidação de Certidões + 30k aprovação CETESB (contaminação) quando for classificado como potencialmente contaminado ou existir a possibilidade de ter contaminação;
Assessorias	R$ 5.000	Custas second opinion Ambiental
Cópias, Plotagens, Autenticações, etc...	R$ 15.000	15k fixo
Contra Partida	R$ 1.332.251	Não temos contrapartida para SP Capital Considerado custas de contaminação/ remediação histórica dos empreendimentos em LB/ m² de terreno
Projeto de criação e Legal	R$ 14.000	1.5k/condomínio de tercerização PL + 4k/condomínio de NBR + 5k complemento plani + 15k para parcelamento do solo (quando houver) + 3.5k para pl grapro (quando houver)
Total	**R$ 1.416.251**	**R$ 1488/uh**

CRITÉRIOS DE INPUT DO SIMULADOR

- Projeto sem desmembramento
- Empreendimento 100% EHIS
- Previsto uma verba de R$ 750k para demolição;
- Não foi prevista verba para remediação; contudo, o CVC estabelece que, em caso de confirmação de contaminação, poderemos antecipar o valor necessário e descontar 100% dos custos de remediação ao limite de 10% do PMG total;

JURÍDICO – Paramétrico de custos

REGIONAL SP

PARAMÉTRICO DE CUSTOS JURÍDICO IMOBILIÁRIO

DADOS		QUANDO APLICAR
Quantidade Unidades	952	
Área Construída	37.842 m²	
Tem SQL?	SIM	
Valor do carne de IPTU	R$ 90.676	Considerar sempre o valor do caner de IPTU do ano de aplicação
Área de Matrícula	20.000	
Retificação?	SIM	Quando a matrícula não tiver o encerramento descrito e/ou detalhamento dos perímetro; Quando houver necessária de de acrescimo ou exclusão de áreas do real para implantação do empreendimento;
Quantos Condomínios?	1	
Quantos Proprietários de terreno?	1	
Parcelamento do Solo?	NÃO	C/ Doação: Quando matrícula tiver mais de 20.000m² ou for necessário abertura de mais lotes
Remembramento de Matrículas?	NÃO	Quando a composição do empreendimento é composta por 2 ou mais matrículas para incorporar;
Com qual valor o terreno será escriturado?	R$ 15.575.961	

ABERTURA	$ FINAL	MÉTRICA
Desdobro de IPTU	R$ 2.500	R$ 2.5k/ condomínio
Instituição de Condomínio	R$ 1.190.000	R$ 1250/uh
Averbação da Construção	R$ 286.086	Área Construída(m²) X 4 meses de Cobrança X Índice Histórico (atual 1,79/m²)
Procuração Societária	R$ 5.000	5k fixo
IPTU (Anual)	R$ 90.676	Valor do caner vigente de IPTU ou em caso de não tenha IPTU, considerado para calculo área da matrícula X Índice Histórico (atual 1,79/m²)
Registro de Incorporação	R$ 299.920	R$ 210/uh + 40k quando houver necessidade de retificação
Honorário Incorporação	R$ -	Não gastamos mais com honorários de incorporação Considerado IPTU Retroativo por não ter SQL: $ IPTU X 5 anos
Cópias e Autenticações	R$ 15.000	15k fixo
Honorário Aquisição	R$ 80.000	120k - 2 ou mais proprietários do terreno 80k - 1 proprietário do terreno
Registro de Escritura	R$ 116.820	Valor do terreno X 0,75%
ITBI Terreno	R$ 467.279	Valor do terreno X 3%
Total	**R$ 2.553.280**	**R$ 2.682/uh**

CRONOGRAMA PRÉVIO

APROVAÇÃO DE CONDOMÍNIO

TERRENO >20.000
APROVAÇÃO EM GRAPROHAB >800UH
ÁREA NÃO CONTAMINADA
IPHAN - SEM APROVAÇÃO
COM RETIFICAÇÃO

PRAZO

23 meses

CIE — CIA — L

MÊS	RESP	ETAPA	STATUS/ PRAZO (dias)	0	1	2	3	4	5	6	7	8	9	10	11	12	13	14	15	16	17	18	19	20	21	22	23	24
0	**PROSP**	**COMITÊ INVESTIMENTO ESSENCIAL**	-																									
	NEG	REUNIÃO PASSAGEM/ PARTIDA	-																									
	JRI	MATERIAL RETIFICAÇÃO	60																									
	JRI	RETIFICAÇÃO MATRICULA	240																									
	NEG	DIRETRIZ SABESP	45																									
	PRÉ-LEG	INVESTIGAÇÃO AMBIENTAL	120																									
	DPP	ELABORAÇÃO AP	30																									
	CUSTOS	PARAMETRIZAÇÃO	30																									
	NEG	CONFIRMAÇÃO FINANCEIRA	10																									
6	**NEG**	**COMITÊ INVESTIMENTO AMPLIADO**	-																									
	GETEC	REUNIÃO DE PASSAGEM	-																									
	GETEC	REVISÃO DE AP	20																									
	GETEC	ENGENHARIA SIMULTÂNEA	45																									
	GETEC	REVISÃO DIRETRIZES SABESP	45																									
	GETEC	ELABORAÇÃO PROJETO SABESP	120																									
	GETEC	APROVAÇÃO SABESP	120																									
	GETEC	EP KIT LEGAL	90																									
	PL	ELABORAÇÃO PL	45																									
	LEG	CETESB (SEM CONTAMINAÇÃO)	120																									
	LEG	ALVARÁ DE APROVAÇÃO E EXECUÇÃO	270																									
	LEG	APROVAÇÃO GRAPROHAB	180																									
	NEG	**COMITÊ DE ESCRITURA/ LANÇAMENTO**	-																									
	JRI	ESCRITURA	30																									
	JRI	REGISTRO INCORPORAÇÃO	30																									
	CRD	LAUDOS CEF	-																									
23	**NEG**	**LANÇAMENTO**	-																									

PRAZO PARA SUPERAÇÃO 1ª ETAPA DE RESOLUTIVAS E PARA APROVAÇÃO DO COMITÊ AMPLIADO: **Jun/26**

Pareceres

Análise da Mancha e Implantação

Prospecção

Operações

Incorporação

Inteligência de Mercado

Financeiro

Anexos

Demanda e Distribuição da Mancha

Potencial de Demanda			Lançados		Lanç + Landbank	
Mancha	CÓD.	Shr.	ANO	MÊS	ANO	MÊS
São Paulo Norte	SZN	30%	2.185	182	2.621	218

Faixas MCMV	Empreendimento	Renda	Lançamento	nov/27	dez/27	jan/28	fev/28	mar/28	abr/28	mai/28	jun/28	jul/28	ago/28	set/28	out/28	nov/28	dez/28	jan/29	fev/29	mar/29	abr/29	mai/29	jun/29	jul/29	ago/29
Faixa 2	Parque Anhanguera F1 (Nilo Cairo)	3.068	nov-26	34	34	34	34	34	34	28															
Faixa 2	Bela Vista Jaragua - F1	2.958	abr-27	57	57	57	57	57	57	57	57	57	57	57	57	1									
Faixa 1	**Pedro de Castilho**	**2.573**	**nov-27**		**53**	**53**	**53**	**53**	**53**	**53**	**53**	**53**	**53**	**53**	**53**	**53**	**53**	**53**	**53**	**53**	**53**	**24**			
Faixa 2	Spazio Primavera I Fase 1	3.380	out-28														51	51	51	51	51	51	51	51	51
Total de Vendas Lançados				**0**	**0**	**0**	**0**	**0**	**0**	**0**	**0**	**0**	**0**	**0**	**0**	**0**	**0**	**0**	**0**	**0**	**0**	**0**	**0**	**0**	**0**
Total de Vendas Lançados + Landbank				**91**	**144**	**144**	**144**	**144**	**144**	**138**	**110**	**110**	**110**	**110**	**110**	**54**	**104**	**104**	**104**	**104**	**104**	**75**	**51**	**51**	**51**
Total Mancha | Faixa 1				*0%*	*37%*	*37%*	*37%*	*37%*	*37%*	*38%*	*48%*	*48%*	*48%*	*48%*	*48%*	*98%*	*51%*	*51%*	*51%*	*51%*	*51%*	*32%*	*0%*	*0%*	*0%*
Total Mancha | Faixa 2				*100%*	*63%*	*63%*	*63%*	*63%*	*63%*	*62%*	*52%*	*52%*	*52%*	*52%*	*52%*	*2%*	*49%*	*49%*	*49%*	*49%*	*49%*	*68%*	*####*	*####*	*####*
Total Mancha | Faixa 3				*0%*	*0%*	*0%*	*0%*	*0%*	*0%*	*0%*	*0%*	*0%*	*0%*	*0%*	*0%*	*0%*	*0%*	*0%*	*0%*	*0%*	*0%*	*0%*	*0%*	*0%*	*0%*

Parecer de I.M sobre a mancha:

O projeto analisado em comitê está em linha com o potencial teórico de demanda calculado para a mancha. (Total Lanç + Landbank)

Canibalização:

Sem Risco de Canibalização

Pedro de Castilho | Mapa Concorrência

Diagnóstico Concorrência

- O projeto está localizado em uma região de borda e não mapeamos nenhum concorrente no raio de 4km.

		Pedro de Castilho
		TENDA
	Distância Tenda (km)	
Região 1 Km	População	9.710
	Dens. Demográfica	3.111
	Renda (R$)	5.043
	Classe Social	C1 (de R$ 3.1K a 5.4K)
	PEA Dia	4.005

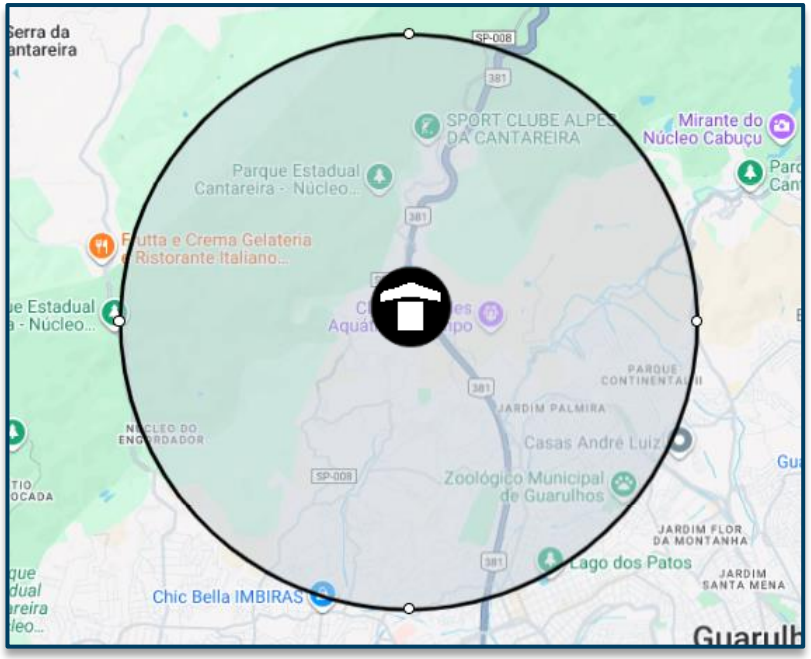

Simulação de Preço

Informações Viabilidade

Projeto:	Pedro de Castilho
Tipo:	**Uh Tipo**
Método	**Vision**
Avaliação	230.000
Renda Inicial (VF)	2.573
Renda Final*	-
% RET1	75%

Tipo:	VF	R$
Ato	0,43	1.078
FGTS	0,54	1.363
Financiamento	96,83%	148.028
Subsídio	96,92%	18.191
Prazo de Pró-soluto	30	30
Pró-Soluto	103,18%	28.936
Preço Raso (RS)	197.597	197.597
TCD	83,36%	21.620
VSO	53	53
Preço de Venda	**223.184**	**223.184**
Elasticidade	-1,778%	-1,778%
Preço de Venda Final	**219.216**	**219.216**

Preço Raso (R$)	**197.597**
% de Raso	**90,14%**
BP25 - Não Inflacionado	**-**
BP25 - Inflacionado	**-**

Análise de Preço

Informações Viabilidade

Projeto:	Pedro de Castilho
Tipo:	**Faixa 2**
Método	**Vision**
Avaliação	230.000
Renda Inicial (VF)	2.573
Renda Final*	-

Tipo:	VF	R$
Ato	0,43	1.078
FGTS	0,54	1.363
Financiamento	96,83%	148.028
Subsídio	96,92%	18.191
Prazo de Pró-soluto	30	30
Pró-Soluto	103,18%	28.936
Preço Raso (RS)	197.597	197.597
TCD	83,36%	21.620
VSO	53	53
Preço de Venda	**223.114**	**223.114**
Elasticidade	-1,778%	-1,778%
Preço de Venda Final	**219.216**	**219.216**
Preço Raso (R$)	**197.597**	
% de Raso	**90,14%**	
Raso Todas as Fases	**197.597**	
Nominal Todas as Fases	**219.216**	

1

Análise de Riscos	Farol IM
IM avalia o Preço Vision como **factível**.	

1) O projeto está inserido em uma região de borda e, apesar do alto volume projetado, a renda estimada no parecer se enquadra na faixa 1, perfil que, no contexto de São Paulo, é o mais adequado para sustentar grandes volumes de vendas. Além disso, a renda estimada está alinhada ao perfil socioeconômico da região, reforçando a coerência do cenário apresentado.

Conforme consta no slide "Panorama de Concorrência, não mapeamos nenhum concorrente na região.

	Preço Real					Preço Normalizado (30m)	
	Avaliação	Preço Raso	Renda Mediana	VSO	PSOL	Δ PSOL	Preço Raso
Pedro de Castilho	230.000	197.597	2.573	53	30	-	197.597
Farol Cantareira	224.661	190.578	2.927	18	13	16.426	207.004
Viva City Jaraguá	222.051	187.494	3.017	30	8	21.392	208.887
Melodia Jaçanã	260.560	228.615	4.052	31	23	8.137	236.752

Ciclo Financeiro – Análise Mancha

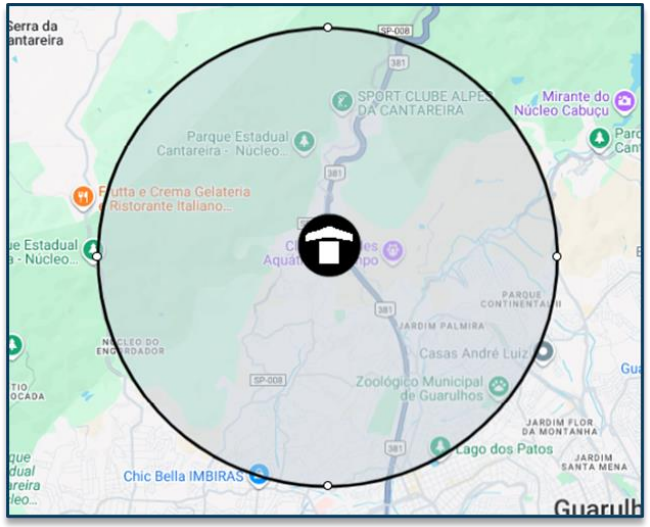

Parecer Ciclo

Ciclo avaliou Preço e VSO como factíveis. O projeto está em uma região na borda de São Paulo, sem concorrentes e com alta demanda para absorção.

Pareceres

Análise da Mancha e Implantação

Prospecção

Operações

Incorporação

Inteligência de Mercado

Financeiro

Anexos

Informações Financeiras

Pedro Castilho - SP - São Paulo Capital

Datas e Prazos

	Compra	Lançamento	Início Obra	Término Obra	LÇTO até IO	IO até TO	Chaves	LÇTO até Chaves
Fase única	dez-25	nov-27	mai-28	jun-30	6 meses	25 meses	nov-30	36 meses

Terreno e Incorridos

TOTAL (R$ + Perm.):	22,96 MM	**Incorrido Terreno:**	0,00 MM	**Área do Terreno (100%):**	20.000 m²	**Área Líquida do Terreno:**	11.003 m²
Cash:	0,00 MM	**Nº de Parcelas Cash :**	0	**Custo de terreno m²:**	1.147,8	**Custo de terreno m² Área Líquida:**	2.086,4
Permuta Financeira:	22,96 MM (11,00%)			**VaR 25 (R$ mil):**	0	**Fração Terreno/Terreno + Custo Obra (%VGV):**	11,0% / 55,7%
Permuta Física:	0,00 MM (0,00%)			**VaR 26 (R$ mil):**	0	**CA Máx/Proj.**	4,0 / 2,8
Ato / %VGV:	0,00 MM / 0,0%			**Incorrido de Construção:**	0,00 MM	**Incorridos de Incorporação:**	0,00 MM

Vendas

Fases	Nº Pavimentos	Preço Raso Unit.	Qtde	Preço Unit.	Aval. CEF	Cond. Parcela	% Pró-soluto	% TCD
Fase Única	T+9	197.616	952	219.216	230.000	96,8%	103,2%	83,4%

Unidades Totais:	952	**Preço Médio:**	219.216	**Renda Média:**	2.573	**ITBI+Emol. Unit. Médio:**	2.554
Unidades Tenda:	952	**Avaliação Média:**	230.000	**Ato:**	1.106 (0,43 Salários)	**Custo do Ciclo Unit.:**	13.799
VSO:	53 Unidades	**VGV Total:**	208.693.903	**FGTS:**	1.389 (0,54 Salários)	**Preço Raso Médio:**	197.616
RET Médio:	1,8%	**VGV Tenda:**	208.693.903	**% em RET 1%:**	75%	**Adc. Tx. de Aceleração Médio:**	750

Construção

Custo Total Unit. | Corrigido:	97.888 | 98.343	**Eventuais:**	4,00%	**Área priv (m²):**	32,00	**Gape / Mês Unit.:**	11,08

Resultado

LI (R$):	**23.117.248**	**LI:**	**20,15%**	**Exposição de Caixa (R$):**	**15.303.013**	**Margem Bruta Econômica:**	**36,02%**
TIR:	**168,31%**	**LI Aprovação:**	**20,00%**	**Ger. Caixa 12 meses (R$):**	**0**	**Margem Bruta REF:**	**38,85%**
Exposição de Caixa:	**6,74%**	**Δ LI:**	**0,15%**	**Ger. Caixa 24 meses (R$):**	**(2.030.058)**	**Margem Rasa Econômica:**	**28,00%**
Payback Contingente (21 m):	**19 m/ (-2 m)**	**LI Resiliência:**	**13,32%**	**Ger. Caixa Marginal (R$):**	**55.418.194**	**Margem Rasa REF:**	**32,17%**
Payback Consolidado:	**19 meses**					**Margem de Contribuição Econômica:**	**25,42%**

Informações Financeiras

R$ Mil - Valores Nominais - Compra	Pedro Castilho	
	Nominal	%
Receita	227.198	100,0%
PIS/COFINS	(2.180)	1,0%
Custo Total	(143.974)	64,0%
Custo Terreno	(22.493)	10,0%
Custo Relacionados a Terreno	(1.199)	0,5%
Custos de Incorporação	(3.972)	1,8%
Custo de Construção	(116.311)	51,7%
Lucro Bruto Econômico	81.043	36,0%
Custo para Rateio	-	0,0%
Lucro Bruto Contábil	81.043	36,0%
Despesas de Selling	(18.615)	8,3%
Contingência	(5.226)	2,3%
Margem de Contribuição	57.202	25,4%
IR e CSLL	(1.784)	0,8%
Margem Líquida	55.418	24,6%
Lucro Bruto REF Unit.	95.259	38,8%
Lucro Raso REF Unit.	71.125	32,2%

R$ Mil - VPL - Compra	Pedro Castilho	
	VP	%
Receitas	114.736	100,0%
PIS/COFINS	(1.084)	0,9%
Custos e Despesas Totais	(90.534)	78,9%
Custo Terreno	(10.873)	9,5%
Custo Relacionados a Terreno	(827)	0,7%
Custos de Incorporação	(2.223)	1,9%
Custo de Construção	(62.803)	54,7%
Despesas de Selling	(11.578)	10,1%
Contingência	(1.343)	1,2%
IR e CSLL	(887)	0,8%
Lucro Imobiliário	23.117	20,1%

Pareceres

Análise da Mancha e Implantação

Prospecção

Operações

Incorporação

Inteligência de Mercado

Financeiro

Anexos

- **DESCRIÇÃO DOS IMÓVEIS:**

  - **IMÓVEL 1 - Lote 01: Matrícula nº 43.192** do 15º CRI de São Paulo/SP, localizado na Rua Ana do Sacramento Andrade, S/N - LT 1 QD C, São Paulo/SP - Cadastro Municipal nº 227.023.0001-2**;**
  - **IMÓVEL 2 - Lote 10: Matrícula nº 40.551** do 15º CRI de Imóveis de São Paulo/SP, localizado na Rua Ana do Sacramento Andrade, 530 - LT A QD A, São Paulo/SP - Cadastro Municipal nº 227.022.0010-7;
  - **IMÓVEL 3 - Lote 09: Matrícula nº 165.342** do 15º CRI de Registro de Imóveis de São Paulo/SP, localizado na Avenida Coronel Sezefredo Fagundes, S/N, São Paulo/SP - Cadastro Municipal nº 227.022.0009-3 (cadastrado em área maior); e
  - **IMÓVEL 4 - Lote 09: Matrícula nº 40.550** do 15º CRI de Registro de Imóveis de São Paulo/SP, localizado na Avenida Coronel Sezefredo Fagundes, S/N, São Paulo/SP - Cadastro Municipal nº 227.022.0009-3 (cadastrado em área maior).

- **PROPRIETÁRIA TABULAR - PROTENDIT EMPREENDIMENTOS IMOBILIÁRIOS LTDA.:**

  - **Título Aquisitivo:** A **PROPRIETÁRIA** adquiriu os **IMÓVEIS** a título de Conferência de Bens, conforme Instrumento Particular de 19/01/2015, registrado sob nº 3522898785-6, em 12/02/2015, na Junta Comercial do Estado de São Paulo – JUCESP, devidamente registrado sob: *(i)* o **nº 5** na matrícula nº 43.192, *(ii)* o **nº 5** na matrícula nº 40.551, *(iii)* o **nº 8** na matrícula nº 165.342, e *(iv)* o **nº 5** na matrícula nº 45.550 – TITULARIDADE REGULARIZADA.

- **CONSIDERAÇÕES JURÍDICAS SOBRE OS IMÓVEIS:**

  - **(a) Retificação:** Será analisado em estudos técnicos, não obstante, destacamos que, em que pese os números de contribuintes averbados nas matrículas dos **IMÓVEIS 2, 3 e 4** não estejam atualizados, conforme consulta realizada no site da PMSP identificamos que a área cadastral dos **IMÓVEIS 1 e 2** conferem com a área real, enquanto em relação aos **IMÓVEIS 3 e 4** constou uma diferença de 0,14m² à menor, ou seja, inferior aos 5% normalmente tolerado pela PMSP; **(b) Loteamento:** Durante a *Due Diligence* será investigado se os **IMÓVEIS** são de origem de um loteamento e em caso positivo verificaremos eventuais restrições; **(c) Desmembramento:** Até o momento não foi informado se será necessário o desmembramento das áreas em referência para consecução do Empreendimento Imobiliário; **(d) Área construída:** *(d.1)* **IMÓVEL 1:** a matrícula menciona "um terreno sem benfeitorias", no entanto, conforme certidão de dados cadastrais emitida pela PMSP consta área edificada de **6.155m²**; *(d.2)* **IMÓVEL 2:** matrícula menciona "um prédio industrial", sem indicar a área construída, no entanto, conforme certidão de dados cadastrais emitida pela PMSP consta área edificada de **18.912m²**; e *(d.3)* **IMÓVEIS 3 e 4:** matrícula do **IMÓVEL 3** menciona "um terreno sem benfeitorias", enquanto a matrícula do **IMÓVEL 4** menciona a existência de uma "casa construída de força do prédio industrial", sendo que ambos estão cadastrados perante a Municipalidade em área maior, cuja certidão de dados cadastrais emitida pela PMSP indica que não consta construção no terreno. Não obstante, a existência de construções irregulares será apurada durante a *Due Diligence*; **(f) Multas:** Durante a *Due Diligence* buscaremos informações se há multas que recaiam sobre os imóveis; **(g) Ônus e Gravames**: *(g.1)* **IMÓVEL 2:** encontra-se alienado fiduciariamente ao BANCO SANTANDER BRASIL S/A., para garantia da dívida no valor de R$ 5.018.683,00, cuja última parcela estava prevista para o dia 15/12/2020, nos termos do R.6, feito na matrícula do imóvel em 18/02/2016; *(g.2)* **IMÓVEL 4:** encontra-se alienado fiduciariamente ao BANCO SANTANDER BRASIL S/A., para garantia da dívida no valor de R$ 5.018.683,00, cuja última parcela estava prevista para o dia 15/12/2020, nos termos do R.6, feito na matrícula do imóvel em 18/02/2016; **(h) Débitos de IPTU**: o **IMÓVEL 2** possui débitos de IPTU abertos e inscritos em dívida ativa, no valor de R$ 3.771.107,91. Ainda, os **IMÓVEIS 2, 3 e 4** possuem um contribuinte antecessor em comum que possui débitos inscritos em dívida ativa, no valor de R$ 65.112,36. **Total global: R$ 3.836.220,27 (três milhões, oitocentos e trinta e seis mil, duzentos e vinte reais e vinte e sete centavos)**; **(i) Ocupação**: conforme declaração prestada pela proprietária os **IMÓVEIS** não se encontram ocupados por terceiros, não existindo locatários, sublocatários e/ou outros ocupantes a qualquer título; **(j) CONDEPHAAT, CONPRESP, IPHAN:** Em *Due Diligence* iremos analisar documentações que informem se há apontamentos; **(k) Desapropriação e Melhoramentos:** Em *Due Diligence* iremos analisar documentações que informem se há apontamentos e **(l) Função Social da Propriedade:** será investigado.

- **CONSIDERAÇÕES PRELIMINARES SOBRE A PROPRIETÁRIA (DD em andamento):**

  - **Foram identificados 4 apontamentos** no TJSP, dos quais destacamos 3 (três) relacionados a Execução Fiscal para cobrança de débitos de IPTU, tendo por objeto IMÓVEIS da aquisição pretendida, a saber:

    - ***(1) Processo: 1537857-95.2021.8.26.0090. Data: 02/06/2021. Valor da causa: R$ 1.929.060,00 -*** *Trata-se de execução fiscal para cobrança de débitos de IPTU relacionados ao contribuinte nº 227.022.0010-7* ***(IMÓVEL 2)****, referente ao exercícios de 2016 e 2017, 2018, 2019 e 2020. No dia 19/11/2024 a Executada apresentou Exceção de Pré-Executividade, no qual aduz que houve a prescrição quinquenal dos débitos discutidos. No dia 13/12/2024 a Exequente solicitou a suspensão da execução pelo prazo de 30 (trinta) dias, diante da necessidade de apuração administrativa, sendo esse o último andamento do processo conforme consulta realizada no dia 03/07/2025.*

    - ***(2) Processo: 1635272-78.2021.8.26.0090. Data: 27/07/2021. Valor da causa: R$ 568.974,00 -*** *Trata-se de execução fiscal para cobrança de débitos de IPTU relacionados ao contribuinte nº 227.022.0010-7* ***(contribuinte antecessor dos IMÓVEIS 2, 3 e 4)****, referente ao exercícios de 2016 e 2017. No dia 19/11/2024 a Executada apresentou Exceção de Pré-Executividade, no qual aduz que houve duplicidade na cobrança. No dia 12/12/2024 a Exequente juntou impugnação aos autos, e a Executada apresentou réplica no dia 17/03/2025, sendo esse o último andamento do processo conforme consulta realizada no dia 03/07/2025.*

    - ***(3) Processo: 1637874-42.2021.8.26.0090. Data: 27/07/2021. Valor da causa: R$ 35.606,00 -*** *Trata-se de execução fiscal para cobrança de débitos de IPTU relacionados ao contribuinte nº 227.022.0007-7* ***(contribuinte antecessor dos IMÓVEIS 2, 3 e 4)****, referente ao exercícios de 2015 e 2016. No dia 19/11/2024 a Executada apresentou Exceção de Pré-Executividade, no qual aduz que houve a prescrição quinquenal dos débitos discutidos. No dia 01/03/2025 a Exequente juntou impugnação aos autos, e a Executada apresentou réplica no dia 07/04/2025, sendo esse o último andamento do processo conforme consulta realizada no dia 03/07/2025.*

CONCLUSÃO.: Em atenção aos apontamentos identificados até a conclusão deste parecer preliminar em nome da **PROPRIETÁRIA**, destacamos que, embora digam respeito à execução de débitos de natureza *propter rem*, tendo por objeto **IMÓVEIS** da aquisição pretendida por V.Sas., conforme previsto na cláusula 4.5 do "*Instrumento Particular de Compromisso de Venda e Compra de Bem Imóvel, com Cláusulas Resolutivas e Outras Avenças*" a ser celebrado entre a **PROPRIETÁRIA** e V.Sas., caso seja constatada, a qualquer tempo, a existência de débitos que onerem os **IMÓVEIS**, cujo pagamento seja necessário à regularização da propriedade e estejam vinculados a períodos anteriores à imissão de V.Sas. na posse, poderão V.Sas. realizar o pagamento de referidos débitos, deduzindo-os das Parcelas iniciais do Preço atribuído a aquisição, caso a **PROPRIETÁRIA** não os faça após decorridos 10 dias que notificada neste sentido. Foi identificada uma Alienação Fiduciária em favor do Banco Santander, vinculada aos imóveis descritos como Lote 10 – Matrícula nº 40.551 e Lote 09 – Matrícula nº 40.550, ambos registrados no 15º Cartório de Registro de Imóveis de São Paulo/SP. Essa garantia está associada a um contrato no valor de R$ 5.018.683,00, cuja última parcela venceu em 15/12/2020. Aparentemente, a alienação pode ser cancelada de forma simples, uma vez que não há registro de protesto ou ação judicial em curso. Adicionalmente, ressaltamos que a apuração da integralidade dos débitos com potencial de onerar os **IMÓVEIS** será realizada no âmbito da *Due Diligence*.

Contratualmente estabeleceu-se que:

O Empreendimento será formado por dois condomínios distintos, a saber: ***(i)* o condomínio a ser executado no Imóvel 1 ("Condomínio 1") Lote 01: Matrícula nº 43.192 ;** e *(ii)* o condomínio a ser executado em novas matrículas resultantes da unificação e do desdobramento das matrículas dos Imóveis 2, 3 e 4 ("Condomínio 2"). O Empreendimento será aprovado, lançado e executado em 3 (três) Fases distintas, a saber: *(a)* a primeira Fase ("Fase 1"), correspondente ao Condomínio 1; *(b)* a segunda Fase ("Fase 2") e *(c)* a terceira Fase ("Fase 3"), ambas correspondentes ao Condomínio 2.

Desde que não tenha sido iniciada a desmobilização das instalações da **PROPRIETÁRIA** existentes nos imóveis que serão destinados ao Condomínio 2, a pedido da **COMPRADORA**, poderá a **COMPRADORA**, declinar da realização do Condomínio 2, sem que isso implique em qualquer penalidade, hipótese em que o negócio objeto do Contrato versará apenas e tão somente sobre a aquisição do Imóvel **1** para realização do Condomínio **1**.

LEGALIZAÇÃO E DPP

ÁREA DE IMPLANTAÇÃO

- O terreno é composto por 1 **matrícula nº 43.192 CRI**, em nome de pessoa jurídica, que totaliza uma área escriturária de **20.000,00m²**;
- O cadastro do imóvel é urbano;
- O cenário foi desenvolvido sobre a real, correspondente a **21.249,74m²**;
- BDT – Sem restrições;

DIRETRIZES URBANÍSTICAS

- O terreno está inserido em **ZPI 2**, conforme **Decreto 63.728/2024**:
- C.A. máximo: **2,25 para EHIS** e **1,87 para EHMP**, com restrição de **gabarito 28m** e **T.O. 0,50%** e **PA 3**, necessário reserva de calçada;

Necessidade de avaliação Jurídica em relação a área Escriturada X Real para que o terreno não tenha necessidade de ser parcelado. Estudo de Massa não considera parcelamento.

O estudo considera implantação de 2 condomínios, sendo:

- **2 Torres** 10 PP x T+9 **1 Torre** 20 PP x T+9
- **1 Torre** 14 PP x T+9 **1 Torre** 22PP x T+9
- **1 Torre** 16 PP x T+9
- **Totalizando = 952 UH**
- **C.A. = Permitido 2,50 | Projetado 1,42**
- **Benefícios Aplicáveis (C.A. virtual):** 50% HIS 1 = 1,12 | Cota Solidariedade = 10% 0,22 + 20% 0,45 = 1,79;
- **Benefícios utilizados:** Não utilizado;

A legislação não exige vaga de garagem, cenário considera 1 vaga PNE;

Usos permitidos: EHIS e EHMP.

LEGALIZAÇÃO E DPP

AVALIAÇÕES AMBIENTAIS

Arbóreo

- Conforme mapa vegetação 1988 o terreno **não** é considerado como Patrimônio Ambiental;
- A propriedade **não** está inserida em Área de Patrimônio Ambiental (APA), Área de Proteção de Mananciais (APRM) e Unidade de Conservação;
- Para o cenário de comitê, conforme parametrização enviada, foi considerado 10% de incidência arbórea.

Hidrografia

- O Imóvel apresenta possível nascente localizada a 15m do lote, o qual deverá respeitar um raio de 50m como área de preservação permanente (APP) em relação ao centro da nascente. Porém em consulta técnica realizada junto à SIURB, não há indicação de córrego e/ou nascente no perímetro. Protocolamos a Certidão de Diretrizes Hidráulicas após o recebimento do Levantamento Planialtimétrico em 02/12.

AVALIAÇÕES AMBIENTAIS

Contaminação

- Terreno não apresenta histórico de contaminação, entretanto por decorrência do uso anterior (indústria) recomenda-se a investigação preliminar seguida da investigação confirmatória.

GRAPROHAB

- Número de UH do estudo EM não supera o 800 UH, não sendo necessário a aprovação;

LEGALIZAÇÃO E DPP

ÓRGÃOS DE PATRIMÔNIO HISTÓRICO

- De acordo com a certidão CIT, o imóvel é isento de aprovação perante ao CONPRESP, CONDEPHAAT e IPHAN;

URBANIZAÇÃO

- Não consta DUP/DIS ou ação visando a desapropriação do imóvel, o mesmo não é atingido por plano de melhoramento viário;
- Conforme croqui patrimonial, não consta área pública no imóvel;

Obrigado(a)