Tenda

sua próxima conquista

Book de Escritura + Lançamento

Regional: SP – Zona Oeste

Projeto: Vila Butantã (Joaquim Guimarães)

Data Comitê: 12/12/2025

Questionamentos – Comitê 08.12.2025

Nome	Vila Butantã - Reversão + Escritura	Observação - Vila Butantã
Andre Luis Menegazzo Padilha	Aprovado	ok
Fabricio Quesiti Arrivabene	Aprovado	Ok
Alexandre Regis de Oliveira	Aprovado	ok
Renan Barbosa Sanches	Aprovado	ok
Amanda da Silva Bezerra	Aprovado	ok
Alejandro Octavio Abiusi	Aprovado	ok
Luiz Mauricio de Garcia Paula	Discutir em comitê	nós temos as contas do trade-off entre a utilização menor do CA em função das soluções de taludes que aumentam a complexidade do projeto vís-a-vís uma solução eventualmente mais cara de talude, mas que possibilitasse aumentar o número de unidades por pavimento?.
Rodrigo Osmo	Discutir em comitê	1. Temos segurança que Sabesp irá bancar as redes de agua/esgoto? Caso haja risco, como impactaria a viabilidade termos que executar essas redes?;

Questionamentos 11.12.2025

1. Luiz Mauricio: Temos as contas do trade-off entre a utilização menor do CA em função das soluções de taludes que aumentam a complexidade do projeto vis-a-vis uma solução eventualmente mais cara de talude, mas que possibilitasse aumentar o número de unidades por pavimento?

Resposta: O adensamento desse projeto está limitado aos afastamentos exigidos pela legislação (linha tracejada vermelho), tanto entre torres, quanto em relação aos limites do terreno. As exigências de afastamento limitam a possibilidade de aumentar o gabarito (vide bloco 2 limitado no T+23).
Devido a declividade do terreno, e o desnível entre os platôs das torres de 7m, mudar a posição da torre para outro sentido aumentando assim o número de unidades por pavimento, além do alto volume de movimentação de terra e contenções por ficarmos "contra" as curvas de nível do terreno, inviabilizaria a aprovação do projeto na prefeitura pois teríamos um desnível acima do permitido para desenvolvimento do platô em relação a cota de acesso pela rua.

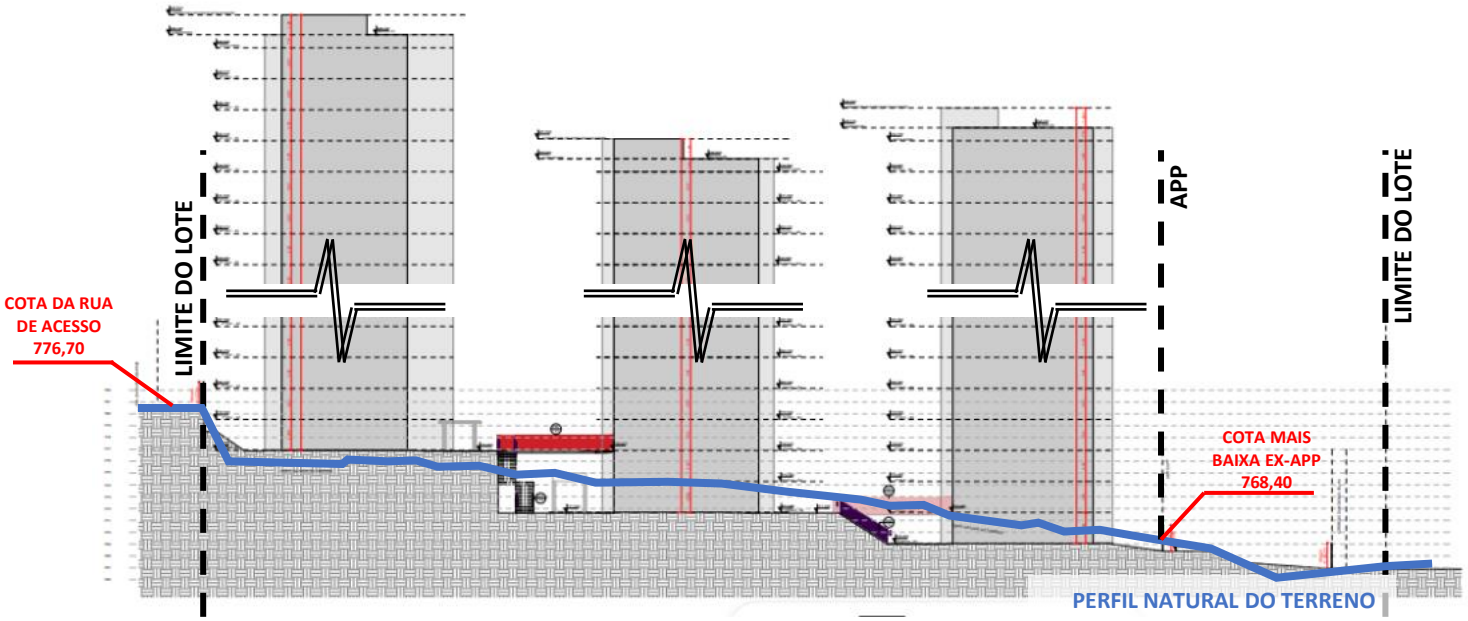

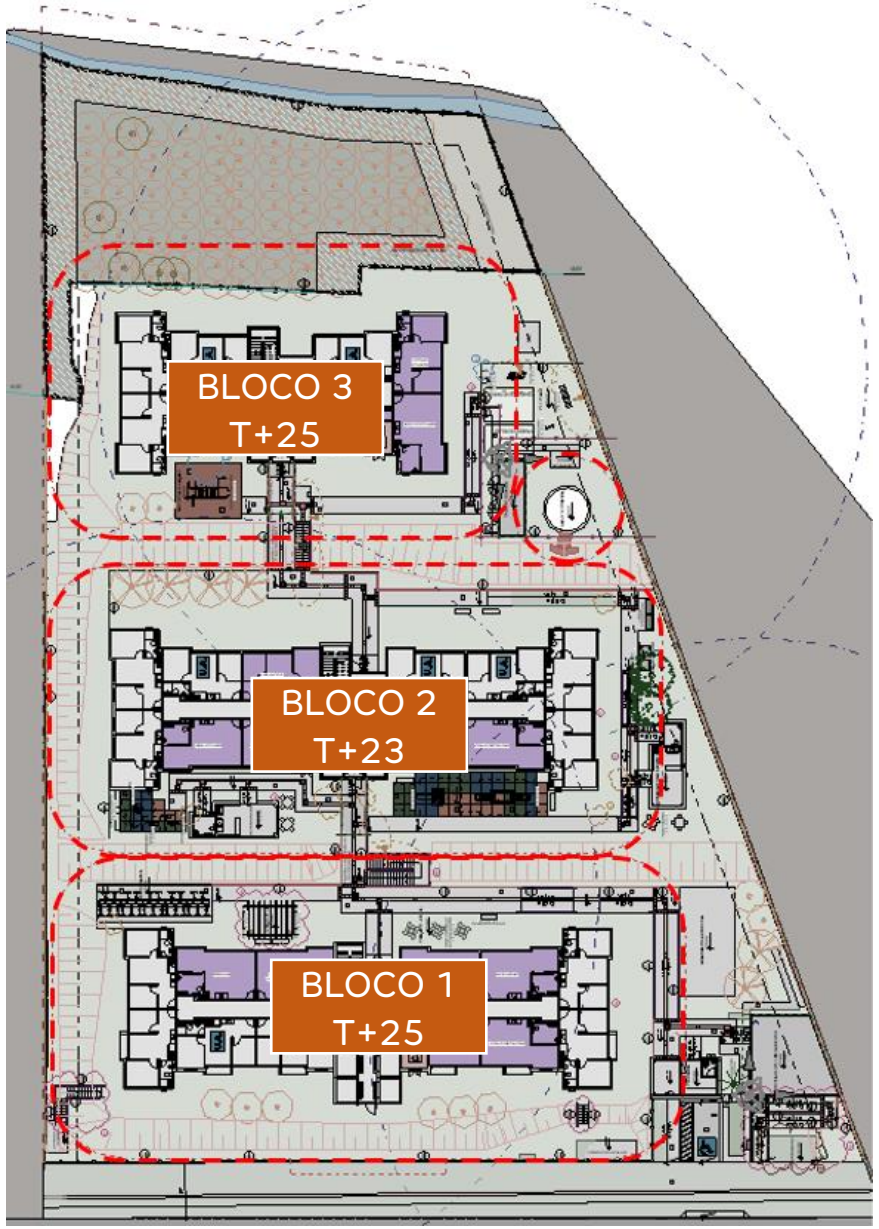

Questionamentos 11.12.2025

2. Rodrigo Osmo: Temos segurança que a Sabesp irá bancar as redes de água/ esgoto? Caso haja risco, como impactaria a viabilidade por termos que executar essas redes?

Resposta: Conforme e-mails abaixo foi formalizado pela SABESP que a execução da rede será feita por eles. O próximo passo é a emissão do termo, que já esta em discussão e deve começar a tramitação na próxima semana, para emissão até janeiro. Importante destacar que a negociação com a Sabesp foi viável por já estarmos com o projeto de redes aprovado pela concessionária – esta aprovação é condição predecessora necessária para análise e cronograma da Sabesp.

Caso a Sabesp não executasse o impacto em **LI seria da perda de 0.83pp, ficando com 19,21%** considerando o formato de reembolso de 40% do orçamento já adotado em outros empreendimentos como Dália e Alvorada Aricanduva.

ENC: EXECUÇÃO DAS REDES DE ÁGUA ...

Denise Dias Du 11:19

Para Tatiana Hagstrom Barreiros Dos Santos; Michel Torao Barreto Mizushima

Confidencial

Você respondeu esta mensagem em 11/12/2025 11:37.
Se houver problemas com o modo de exibição desta mensagem, clique aqui para exibi-la em um navegador da Web.

De: Ana Maria de Campos Rocha <amrocha@sabesp.com.br>
Enviado: quinta-feira, 11 de dezembro de 2025 11:17
Para: Igor Breno Braz de Oliveira <ibraz@tenda.com>
Cc: Ivair Clem <iclem@sabesp.com.br>; Denise Dias Ducatti <dducatti@tenda.com>; Luciano Gattai Candido <lgcandido@sabesp.com.br>
Assunto: RE: EXECUÇÃO DAS REDES DE ÁGUA E ESGOTO - VILA BUTANTÃ

CUIDADO: Esta mensagem foi enviada por um e-mail externo. Somente abra links ou anexos caso confie no remetente.

Bom dia.

A Sabesp executará as obras, de acordo com as definições entre o empreendedor e a Sabesp, em reunião de 03/12/25.

Atenciosamente

Ana Maria de Campos Rocha
amrocha@sabesp.com.br
Analista Administrativo
Micro Universalização e Empreendimentos Imobiliários
(11) 3388-9440/ (11) 94543-2038
sabesp

Fw: EXECUÇÃO DAS REDES DE ÁGUA E ESGOTO - VILA BUTANTÃ

Denise Dias Ducatti 12:28

Para Tatiana Hagstrom Barreiros Dos Santos; Michel Torao Barreto Mizushima

Confidencial

Você encaminhou esta mensagem em 11/12/2025 13:50.
Se houver problemas com o modo de exibição desta mensagem, clique aqui para exibi-la em um navegador da Web.

CUIDADO: Esta mensagem foi enviada por um e-mail externo. Somente abra links ou anexos caso confie no remetente.

Prezados, bom dia!

Segue abaixo conforme solicitado:

1. A diretoria OO executará a obra pela Global? (x) sim ( ) não

- Caso negativo, informar motivo;

- Caso positivo, informar prazo para realização da obra (Previsão: data, ano).

Tendo em vista que a Diretriz informa que a implantação do Empreendimento será em 30/04/2029, planejaremos a execução para 2º semestre de 2028,

2. Existe rede no local? ( ) sim (x) não

- Caso negativo, informar a extensão para atendimento.

Conforme a Diretriz existem 2 opções para Água: Para o abastecimento haverá a necessidade da implantação de um reforço de rede de diâmetro nominal Ø 400 mm, por uma distância aproximada de 550 metros, e continuando na Rua Cachoeira Poraque e em diâmetro nominal Ø 200 mm por uma distância de 250 m interligando na rede Ø 160 ou Deverá ser executado considerando a interligação na rede de diâmetro 300 mm localizada à Rua Ivan Popov, conforme croquis anexos; Para o abastecimento haverá a necessidade da implantação de um reforço de rede pelo de diâmetro nominal Ø 200 mm, por uma distância aproximada de 500 metros mm na Rua Cachoeira do Arrependido.

Conforme a Diretriz para Esgoto: Para a interligação do empreendimento ao sistema de esgotamento sanitário da Sabesp, deverá ser executado o remanejamento da atual rede de esgoto em PVC, com diâmetro nominal de 150 mm, existente na rua Joaquim Guimaraes, substituindo-a por uma nova rede em PVC com diâmetro nominal de 300 mm; A nova tubulação deverá ser implantada desde a frente do imóvel até a rede existente da Sabesp, localizada na Rodovia Raposo Tavares, composta por tubulação em PEAD com diâmetro de 300 mm, conforme indicado no croqui anexo;

Grato e à disposição

One Page – Vila Butantã - Aprovação

[1]

Cidade	São Paulo	Mancha de demanda	SP - SZO2 - São Paulo Oeste 2
Regional	SP	Cluster MPR	1 - Vermelho
Cenário de Aprovação	Aprovação	Tipo de Aprovação	Consolidado
Fase Anterior	N/A		
Tipo de Comitê	Reversão Escritura/Lçto.	Versão da VF	Versão 1.0: Dez

[2]

Unidades (Fases)	796 (1)	CA Máx | Proj	6,0 | 4,5
Unidades com Vaga (%)	0 (0%)	Escritura | Lançamento	dez/25 | jan/26
Unidades com Varandas (%)	150 (19%)	Tipologia	F2E - CDW

[3]

Valor Líquido do Terreno (% VGV)	15.123 (7,9%)	Un. Perm. Fís (% Ter)	0 (0,0%)
Cash (Correção)	0 (N/A)	%VGV Perm Fin Líquida (% Ter)	7,9% (100,0%)
Valor R$/m²	3.621	VAR (%VGV)	000 (0,0%)

[4]

Custo Construção (%VGV)	85.911 (45,0%)	Indireto Unit.	19.513
Prazo da Obra (meses)	27	Torre Unit.	66.658
Custo Total Unit. (LPU):	107.929 (96)	Infra Unit.	10.788
Início de Obra	jul-26	Fundação Unit.	6.929

[5]

Preço Nominal Unit.	239.881	VSO	45
Preço Raso Unit.	219.296	Referência	Vision
Avaliação Unit.	268.088	Renda (% em RET 1%)	3.700 (20,3%)

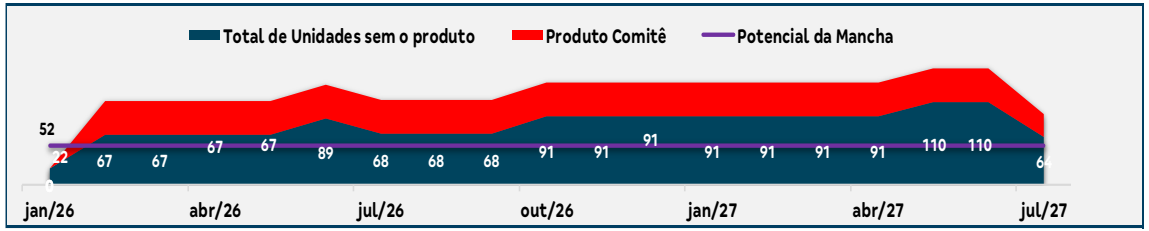

LI (Régua):	20,0% (20,0%)	Margem Bruta Econômica:	37,1%
LI Marginal:	20,2%	Margem Rasa Econômica:	30,3%
Margem Bruta REF:	40,1%	Margem Contribuição Econômica:	26,1%
Margem Rasa REF:	34,5%	Exposição (% VGV):	11.753 (6,2%)
TIR:	151,4%	VGV Total:	190.945
Payback Contingente (21 m) :	19 m/ (-2 m)	Ger. Caixa 12 meses (R$):	(9.932)
Payback Consolidado:	19	Ger. Caixa 24 meses (R$):	13.453

Destaques

Objetivo: Escriturar + Lançar 796 unidades.

[1] Localização: O Terreno está localizado na Rua Joaquim Guimarães, 94 – Butantã, mancha ZO2 - Zona Oeste de São Paulo, ao lado da Rodovia Raposo Tavares e divisa com município de Osasco.

[2] Projeto: O terreno possui área de 6.000 m² e área líquida de 4.746.16m². Composto por 796 unidades, sem vagas, fase única, com a tipologia F2EPlus CDW T+25 e T+23, sendo 2 torres 12pp, 1 torre 8pp. CA projetado: 4,49x (~75% do potencial – CA máx 6x). A impossibilidade de aumento de CA decorre da restrição de APP, reserva de calçada, limites de recuo entre torres ocasionando que uma torre tenha T23 (demais T25), e também pela topografia do terreno.

[3] Condição Comercial: (detalhes slide 7)
a) 100% permuta financeira com fração de 9% bruta, sendo aplicado desconto de 12% (referente a despesas) gerando um repasse líquido mensal de 7,9%.
b) Repasse mínimo garantido de R$ 13MM– líquido e sem reajuste, atingível até o 42º mês após o lançamento;
c) Adiantamento de R$ 1MM à serem pagos, sendo, 150 mil antes da escritura e 850 mil pós lavratura da escritura. O abatimento acontecerá nos primeiros repasses do fluxo da permuta financeira no percentual de 50% de cada repasse mensal, até o atingimento do valor total da antecipação;
d) Garantia: escritura de confissão de dívida;

[4] Custo de Construção: A viabilidade considera execução pela SABESP de 100% das redes de esgoto e água. Totalizando um custo final de R$ 107.929/uh, sendo que:
- R$ 107.041/uh no custo I – Condomínio
- R$ 888/uh no custo II - infra externa. O pleito da execução da execução foi deferido em reunião de partida no 03/dez, com formalização até janeiro-26.

*Observação: Folha Rosto considera valor total sem a execução da SABESP de 6.761/uh.

[5] Preço e VSO: Apesar de o total de unidades previsto para a mancha ser maior que o potencial de demanda calculado por I.M, não devemos ter problemas com VSO, pois os projetos Max Vila Sônia, Vila Butantã e Life Jaguaré estão na divisa com outras manchas e devem capturar demanda dessas regiões e municípios lindeiros. O projeto foi bem avaliado pela CEF em 290k uh com varanda e 263k uh sem varanda – delta varanda de 27K.

One Page – Vila Butantã- Real

[1]

Cidade	São Paulo	**Mancha de demanda**	SP - SZO2 - São Paulo Oeste 2
Regional	SP	**Cluster MPR**	1 - Vermelho
Cenário de Aprovação	Real	**Tipo de Aprovação**	Consolidado
Fase Anterior	N/A		
Tipo de Comitê	Reversão Escritura/Lçto.	**Versão da VF**	Versão 1.0: Dez

Unidades (Fases)	796 (1)	**CA Máx | Proj**	6,0 | 4,5
Unidades com Vaga (%)	0 (0%)	**Escritura | Lançamento**	dez/25 | jan/26
Unidades com Varandas (%)	150 (19%)	**Tipologia**	F2E - CDW

Valor Líquido do Terreno (% VGV)	15.024 (7,9%)	**Un. Perm. Fís (% Ter)**	0 (0,0%)
Cash (Correção)	0 (N/A)	**%VGV Perm Fin Líquida (% Ter)**	7,9% (100,0%)
Valor R$/m²	3.597	**VAR (%VGV)**	000 (0,0%)

Custo Construção (%VGV)	85.911 (45,3%)	**Indireto Unit.**	19.513
Prazo da Obra (meses)	27	**Torre Unit.**	66.658
Custo Total Unit. (LPU):	107.929 (96)	**Infra Unit.**	10.788
Início de Obra	mai-26	**Fundação Unit.**	6.929

[2]

Preço Nominal Unit.	238.310	**VSO**	45
Preço Raso Unit.	217.414	**Referência**	Vision
Avaliação Unit.	268.088	**Renda (% em RET 1%)**	3.700 (20,3%)

Fase de Lançamento - Uso exclusivo para o Ciclo Financeiro		**Preço Raso Inf. Médio Unit.**	221.522
Preço Inf. Médio Unit.	242.782	**Margem Bruta REF (%)**	40,2%
Custo Inf. Médio Unit.	145.254	**Margem Rasa REF (%)**	34,4%

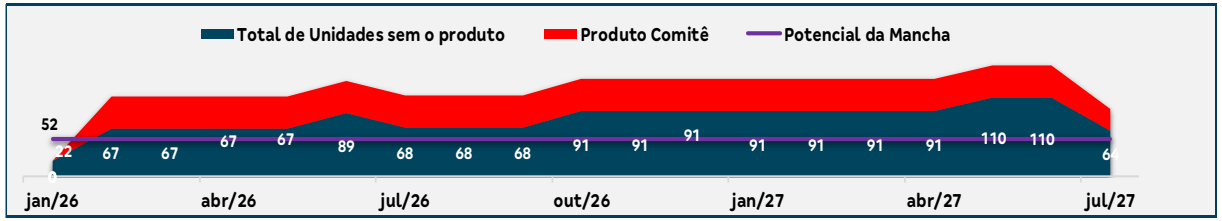

LI (Régua):	**19,7% (20,0%)**	**Margem Bruta Econômica:**	37,1%
LI Marginal:	19,8%	**Margem Rasa Econômica:**	30,2%
Margem Bruta REF:	40,2%	**Margem Contribuição Econômica:**	26,1%
Margem Rasa REF:	**34,4%**	**Exposição (% VGV):**	14.207 (7,5%)
TIR:	138,7%	**VGV Total:**	**189.694**
Payback Contingente (21 m) :	**19 m/ (-2 m)**	**Ger. Caixa 12 meses (R$):**	(11.759)
Payback Consolidado:	19	**Ger. Caixa 24 meses (R$):**	16.143

Destaques

[1] Geral:
Todas as observações do slide anterior do cenário aprovação, são aplicáveis para este slide do cenário real. A única diferença entre os cenários, é a folga de início da regra ouro (aprovação) X cenário do PCP 171 (real), impactando o prazo de PSOL e por consequência no Preço de venda.

[2] Preço de venda
Adotando o PCP 171, gerando um PSOL de 31 meses; 18 meses de venda com VSO de 45.

Pareceres

Condições do Negócio

Análise da Mancha e Implantação

Operações

Inteligência de Mercado

Financeiro

Anexo

Farol Pareceres

Área	Riscos Associados	Parecer	Criticidade
Jurídico	Concluímos que não houve alteração da situação jurídica retratada no Relatório Principal de Due Diligence de 23/05/2024, razão pela qual, ratificamos que não existem óbices e/ou elementos jurídicos intransponíveis capazes de impedir ou colocar em risco a aquisição pretendida.	Ok	
Legalização	Ok, não foram identificados riscos associados ao lançamento do empreendimento.	Ok	
Produto	Ok, sem ressalvas	Ok	
GETEC/Custos	Orçamento desenvolvido com EP em andamento. PCP 171 considera lançamento em fev/26	Ok com ressalvas	
Logística	Ok. Obrigatório concretagem pelo viário público devido a não existir outra possíbilidade de concretagem. Necessário prever a licença.	Ok	
Inteligência de mercado	Ok, factível	Ok	
Comercial/Ciclo	Ok	Ok	
Estudos Econômicos	Ok	Ok	

Pareceres

Condições do Negócio

Análise da Mancha e Implantação

Operações

Inteligência de Mercado

Financeiro

Anexo

Condições do Negócio

Jun/2024

Valor de Negócio: R$13,5MM
Correção: IPCA , com prazo para quitação em 36 meses contados do lançamento.
Fração: 10%
Cash: Sinal de R$ 2MM na escritura
Permuta Finan.: 100%
Comissão: 500.000 pago pelos vendedores;

Dez/2025

Valor de Negócio: R$13 MM sem correção
Correção: Sem reajuste , com prazo para quitação em 42 meses contados do lançamento. (aumento do prazo de quitação).
Fração: 9% (redução de 1%)
Cash: Sinal de R$ 1MM, sendo 150 mil antes da escritura e 850 mil na lavratura da escritura
Permuta Finan.: 100%
Comissão: 360.000 pago pelos vendedores;

CVC → 1º Aditamento- Reneg → 2º Aditamento- Reneg

Dez/2024

Valor de Negócio: R$13MM Redução de 500K, valor garantido alterado para "sem correção"
Correção: Sem reajuste , com prazo para quitação em 36 meses contados do lançamento.
Fração: 10%
Cash: Adiantamento de R$1MM na escritura Redução do adiantamento em 1MM
Permuta Finan.: 100%
Comissão: R$ 360.000,00 em 10 parcelas mensais após EVC redução de 140k e parcelamento em 10x

Condições do Negócio- Extensão de Rede

O terreno possui extensão de rede de água e esgoto com alto custo (~5MM) a serem executadas. O negócio firmado no 1º aditamento considerava divisão:

- 55% a ser pago pelos Vendedores.
- 45% a ser pago pela Compradora.

- Reajustado pelo INCC/FGV com limite de 7% ao ano por até 24 meses.
- **Conforme mencionado no Onepage (Slide 2) no dia 3/dez, ocorreu a reunião de partida com a SABESP, onde foi deferido o pleito de execução da rede de água e esgoto, com a obrigação da Tenda de emitir as licenças necessárias. Dessa forma, não haverá mais divisão de custos com os Vendedores.**

Próximas Etapas

- 1ª ETAPA: Aprovação de Projeto de Água de Esgoto pela SABESP- OK, superado- projeto aprovado em 11/11.
- 2ª ETAPA: Formalização junto a Sabesp quanto a execução total da extensão de rede- Prazo janeiro/26

Orçamento Atual

Valor total da extensão de rede: ~5MM, sendo:

CUSTO TOTAL II	R$ 5.381.778	R$ 6.761
URBANIZAÇÃO	R$ 56.764	R$ 71
DRENAGEM	R$ 100.000	R$ 126
EXTENSÃO ELÉTRICA	R$ 150.000	R$ 188
EXTENSÃO HIDRÁULICA	R$ 5.075.014	R$ 6.376

- **DESCRIÇÃO DO IMÓVEL:** Matrícula 22.411 ("Imóvel"), do 18º Oficial de Registro de Imóveis de São Paulo/SP, situados na Rua Joaquim Guimarães, nº 94, Butantã, em São Paulo/SP. Cadastro Municipal (contribuinte): 186.002.0019-8.

- **PROPRIETÁRIOS:** Fernando Antônio Magalhães, Hermínio Ribeiro Magalhães, Vera Lucia Brandão Rodrigues, José Antônio Brandão Rodrigues e Carmen Lucia Jaques Rodrigues ("Proprietários").

- **CONSIDERAÇÕES JURÍDICAS SOBRE O IMÓVEL**: conforme o relatório dos Estudos Jurídicos emitido pelo RAA Advogados, datado de 13/09/2021, e Estudos Técnicos emitido pela Top Perícia, em 20/09/2021, foram apontadas, em suma, as seguintes considerações: **(a) Retificação:** no comparativo entre a área física e registraria do Imóvel, verificou-se que encontra-se muito próxima em todos os segmentos do perímetro e na área encerrada do terreno, apresentando diferenças significativas nos segmentos das laterais, devido à configuração do Córrego da Moenda Velha, sendo que na lateral esquerda, de quem da rua o olha, a diferença é superior a 5% (cinco por cento). Destacou, ainda, que consta na quadra do imóvel rua sem saída ou imóveis que podem apresentar características de "Vila". Por fim, concluiu que o Imóvel é tecnicamente perfeito, apresentando todas as medidas perimetrais e a área final encerrada dos terrenos, sendo possível a retificação de área nos moldes do Inciso II, do artigo 213, da Lei de Registros Públicos; **(b) Regularidade Ambiental:** os estudos recebidos não abrangeram aspectos ambientais do Imóvel. Necessário confirmação técnica; **(c) Loteamento:** o Imóvel não foi objeto de parcelamento do solo e, diante da inexistência de loteamento, não há restrição construtiva que possa impactar o Empreendimento. Todavia, recomendou-se a realização de estudo técnico junto a Prefeitura de São Paulo, para verificar restrições construtivas nos arquivos dos entes Municipais que não tenham sido objeto de inscrição ou registro nos Cartórios de Registro de Imóveis competentes; **DD IMÓVEL**: **(a) Área Construída**: 1.815,00m², averbada na matrícula e regular perante PMSP; **(b) Débitos Imobiliários**: não há; **(c) Multas Administrativas:** em emissão; **(d) Ônus e Gravames**: não há (servidão de passagem e usufruto cancelados); **(e) Ocupação**: Comodato formal Motel Raposo Tavares; **(d) TAC**: não há; **(g) CONDEPHAAT, CONPRESP, IPHAN**: certidões negativas; **(h) Desapropriação e Melhoramentos:** negativas, exceto pela certidão de desapropriação que indica a existência do DUP nº 54.195/2013, já caduco. Ainda, não consta registro de ação ajuizada visando a desapropriação do Imóvel; **(i) Função Social da Propriedade**: consultas negativas; e **(j) Contas de Consumo:** pendentes.

➢ **PROPRIETÁRIOS:**

- **Fernando Antônio Magalhães:** todos os apontamentos identificados em nome de Fernando tiveram os respectivos riscos reputados como remotos de impactarem a aquisição pretendida, sendo que com relação a 04 (quatro) desses apontamentos judiciais, conforme recomendado no Relatório Principal de Due Diligence, Fernando declarou, por meio de declaração formal assinada em 05/06/2024, não figurar como parte, e que, portanto, são casos de homonímia.

- **Vera Lucia Brandão Rodrigues:** em que pese a existência de tais débitos em aberto, considerando que não constam, até a data da emissão do referido relatório, débitos inscritos em dívida ativa, por ora, ficam afastados os riscos de caracterização de fraude à execução, visto que o entendimento jurisprudencial e artigo 185 do Código Tributário Nacional dispõem que a presunção de fraude ocorre quando existe, concomitantemente ao tempo da alienação, crédito tributário regularmente inscrito em dívida ativa.

➢ **CONCLUSÃO:** À exceção das ressalvas acima, bem como considerando que há poucas certidões pendentes de emissão, concluímos que não houve alteração da situação jurídica retratada no Relatório Principal de Due Diligence de 23/05/2024, razão pela qual, ratificamos que não existem óbices e/ou elementos jurídicos intransponíveis capazes de impedir ou colocar em risco a aquisição pretendida.

Pareceres

Condições do Negócio

Análise da Mancha e Implantação

Operações

Inteligência de Mercado

Financeiro

Anexo

Mancha de Demanda

MANCHAS DE DEMANDA
• SZO– São Paulo Oeste

Lançamento

1. Life Jaguaré
2. Máx Vila Sônia

LandBank

3. Villa Butantã
4. Essence Butantã
5. Bosque | Paços Das Artes
6. Terrazo Butantã

Cluster MPR – (Comitê)
● Cluster 1 - Vermelho

Região
Borda

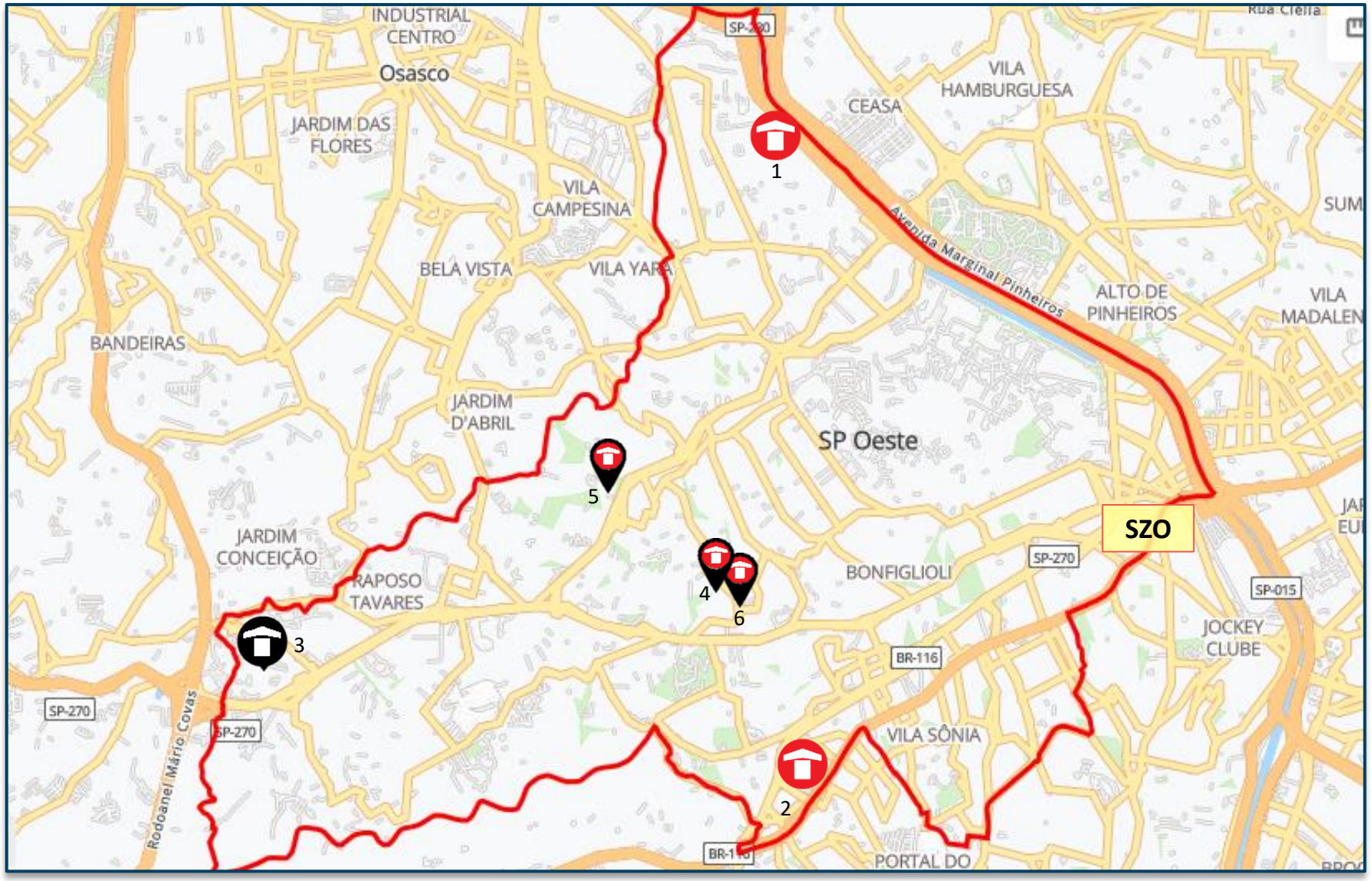

Lançados *LandBank* *Comitê*

Localização – Rua Joaquim Guimarães, 94 – Butantã – São Paulo - SP

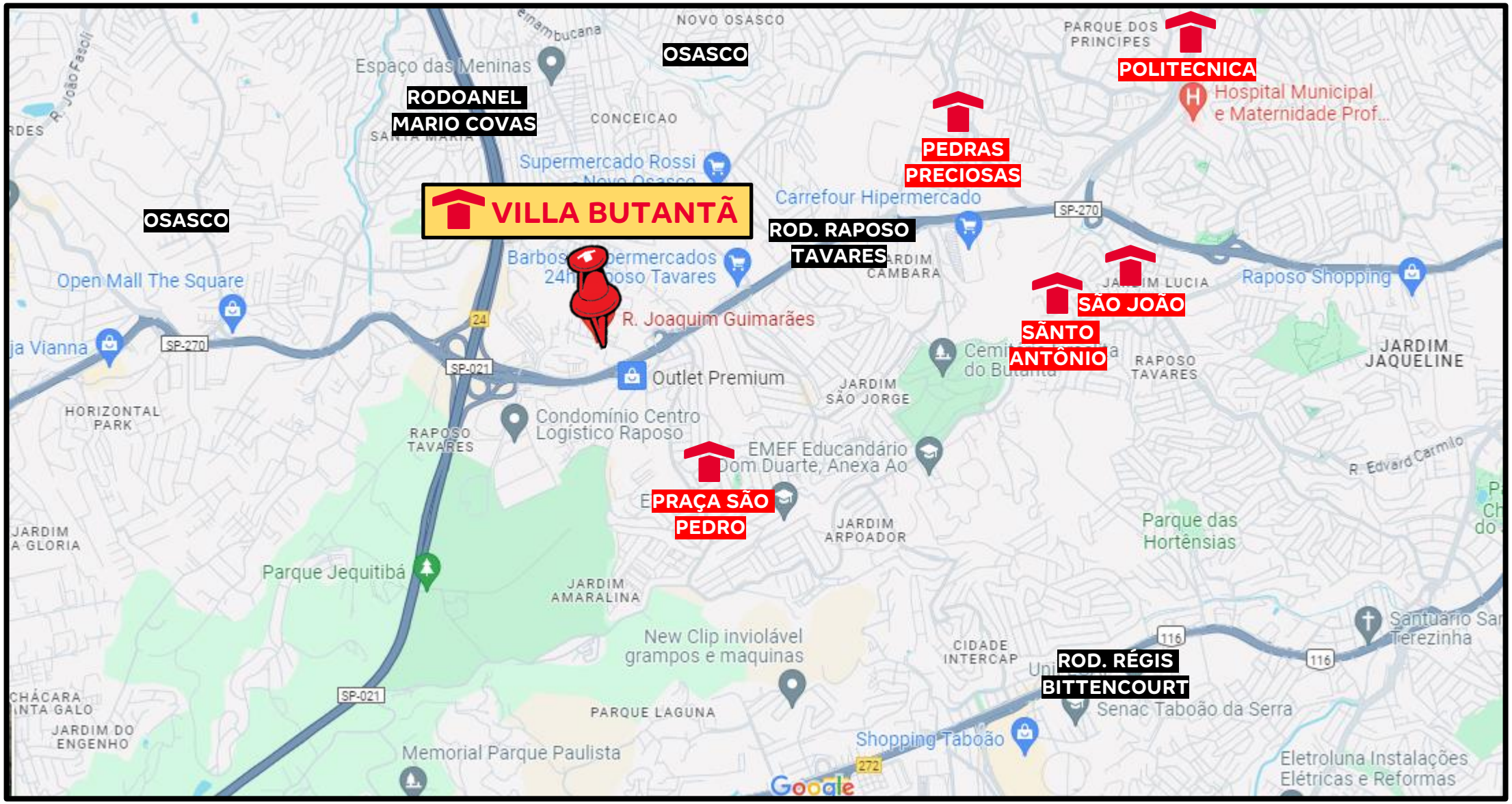

Localização – Rua Joaquim Guimarães, 94 – Butantã – São Paulo - SP

PRODUTO

Empreendimento Vila Butantã I Reversão

Informações Gerais – Condomínio Único			
Terreno	Área terreno	6.000m²	
	App/fna	677,49m² | 77,13m²	
	Reserva de calçada/ melhoramento víario	282,48	
	Área liquida	4.746.16m²	
	Zoneamento	Zeis-03	
	Ca máximo	6,00	ZONA: 4,0
			INCENTIVO HIS: 2,00
	Ca projetado	4,49	
	Gabarito máximo	NA	
Geral	Total uh	796	
	Total de vagas	02 externas	
Tipologia	Tipologia	SP F02E SP PCT	
	Gabarito	T+23 | T+25	
	Lâmina	1x 12PP (T+23) | 1x 12PP (T+25) | 1x8PP (T+25)	
	Área privativa	32,80m²	
Condomínio	Unidade pcd	24 UH	
	Unidade lazer|técnica	15	
	Torres	03	
	Fases	01	
Lazer	Lazer coberto	2 Churrasqueiras, Salão de Festas Gourmet, Brinquedoteca, Espaço Office, Espaço Teen, Espaço Saúde, Espaço Oficina, Sport Bar, Minimarket	
	Lazer descoberto	Pet Place, Horta, Play baby, Play kids, Funcional, Multipla Estação, Praça de Jogos, Espaço Relax	

LEGENDA:

01 FNA Drenagem

02 Área Técnica

03 Áreas de Lazer

Varanda

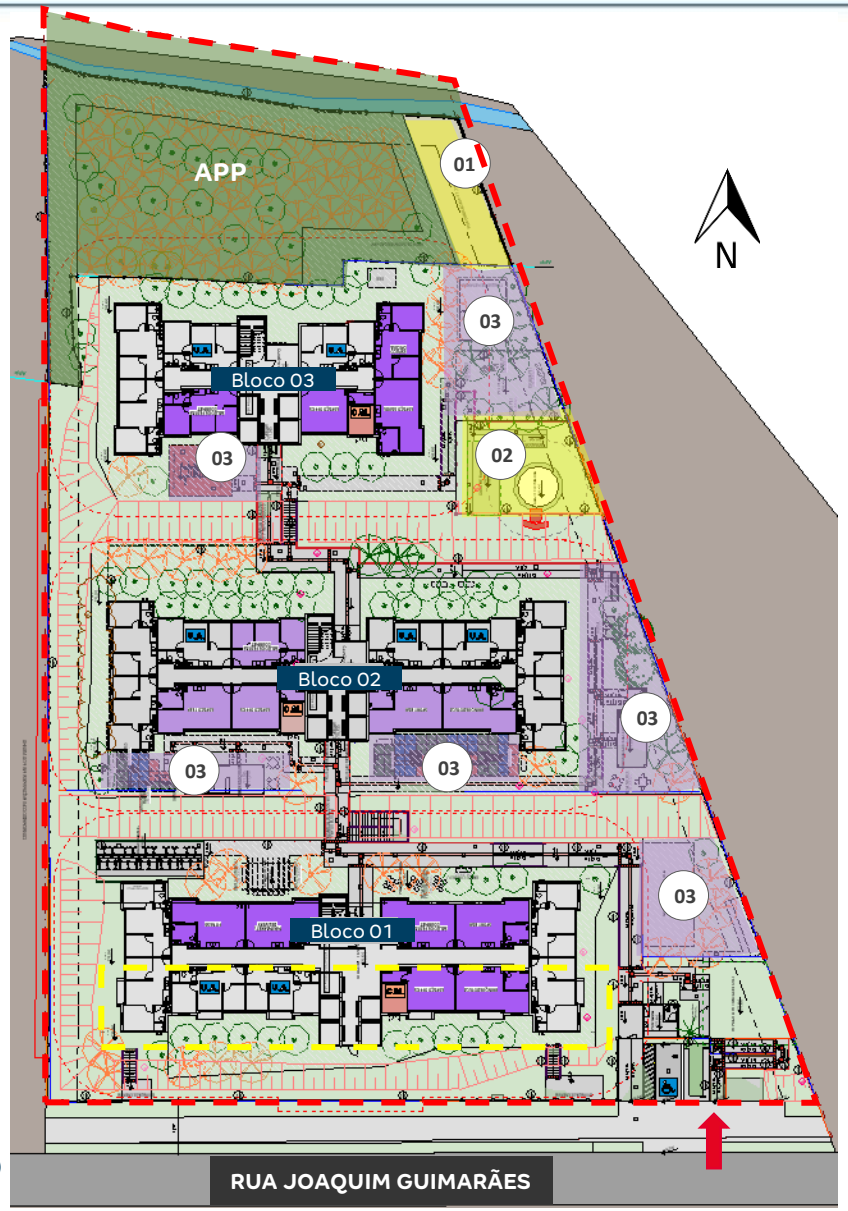

IMPLANTAÇÃO

Empreendimento Vila Butantã

	Descrição	Criticidade	Observação
Usabilidade	**Acesso Empreendimento**		
	Percurso do pedestre até torre		*Torres com fruição + Passarela* *Para atender o fluxo de pedestres na implantação será necessário a contratação de elevador especifico que o comporte*
Diferencial produto	**Faixa de renda**	2	
	Prime	Não	
	Supercondomínio	Não	
	Atributos Infra	Sim	*Quadra e Churrasqueiras.*
	Atributos Torre	Sim	*Varanda em uma das torres*
	Edifício Garagem	Não	

A impossibilidade de esgotar o CA decorre principalmente do recuo exigido pelas torres, em especial a torre T+23, somado às restrições de APP, à necessidade de áreas de lazer descobertas e às limitações impostas pelo desnível do terreno, que demandam soluções de taludes e aumentam a complexidade do projeto.

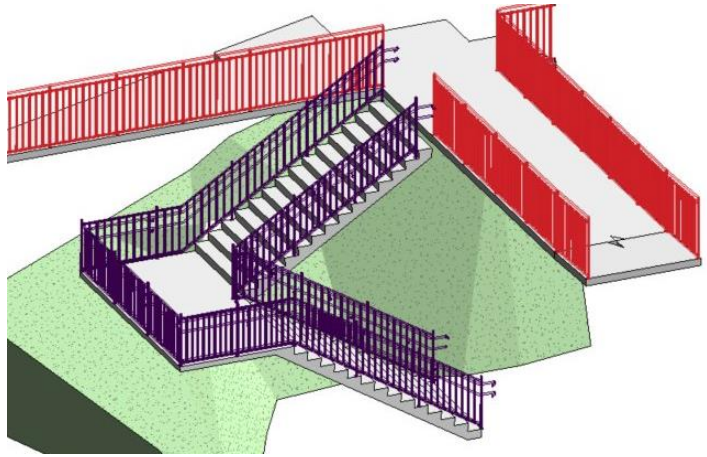

Detalhe 1- Acesso ao Bloco 3

Detalhe 2- Acesso ao Bloco 3

Empreendimento Vila Butantã I Reversão

Fase unica				
Módulo	**Blocos**	**UH**	**Vagas**	**Parecer**
Módulo 01	1 bloco 12PP (T+23) 1 bloco 8PP (T+25)	490 Uh (Sendo 18 U.A)	02 vagas externas	
Módulo 02	1 bloco 12PP (T+25)	306 Uh (Sendo 06 U.A)	00 vagas	

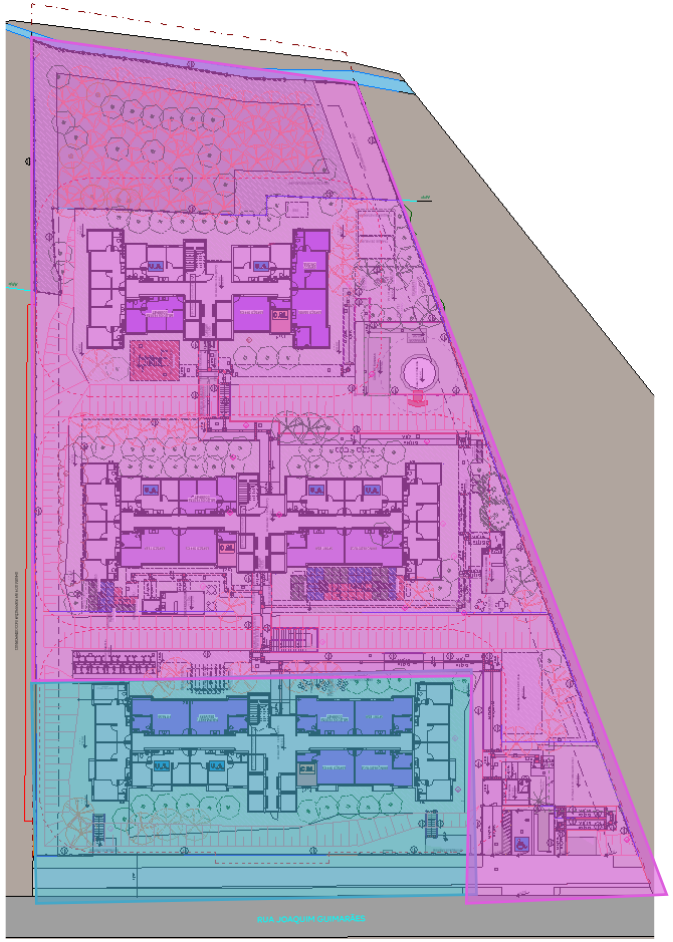

PRODUTO

Empreendimento Vila Butantã I
Reversão

DE:

TORRES: GRUPO B PCT
GABARITO: T+17
TOTAL UH: 707
CAB | CAM: 1,00 | 4,00
CAP PROJ.: 3,77

PARA:

TORRES: MODULARES COM ELEVADOR
GABARITO: T+23 E T+25
TOTAL UH: 796
CAB | CAM: 1,00 | 6,00
CAP PROJ.: 4,49

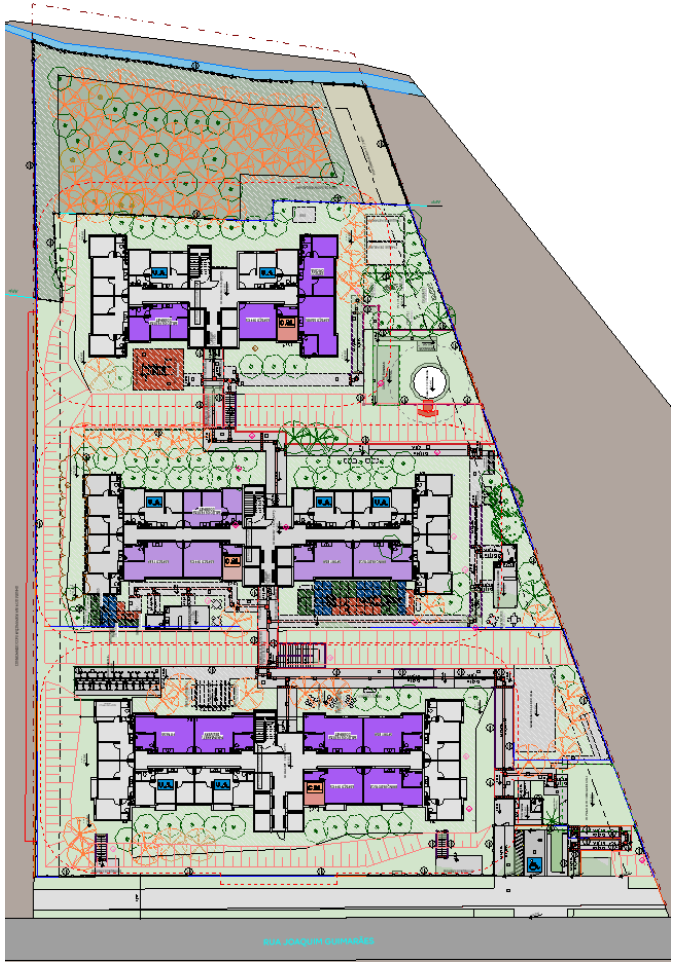

Pareceres

Condições do Negócio

Análise da Mancha e Implantação

Operações

Inteligência de Mercado

Financeiro

Anexo

Custo de Construção

	VILA BUTANTÃ R01	VILA BUTANTÃ R00	VILA BUTANTÃ PARAMETRIZAÇÃO R09	VIVER BEM - USP LESTE LVS	PARQUE LIMÃO F1+F2 LVS
Torres	3	3	3	2	2
Unidades Construídas	808	808	808	672	832
Unidades Vendidas	796	796	796	666	823
Cidade	São Paulo - SP	São Paulo - SP	São Paulo - SP	São Paulo - SP	São Paulo - SP
Produto / Selo	F2EPlus - V0200 CDW	F2EPlus - V0200 CDW	F2EPlus - V0200 CDW	F2EPlus	F2EPlus
Tipologia	1 Torre | T+25 | 12PP	1 Torre | T+25 | 12PP	1 Torre | T+25 | 12PP		
Tipologia	1 Torre | T+23 | 12PP	1 Torre | T+23 | 12PP	1 Torre | T+23 | 12PP		
Tipologia	1 Torre | T+25 | 08PP	1 Torre | T+25 | 08PP	1 Torre | T+25 | 08PP		
Atributos	150 Varandas	150 Varandas	150 Varandas		
Projeto Infra	ED	ED	AP		
Projeto Torre	ED	ED	AP		
Mês Base	dezembro-25	novembro-25	outubro-25	setembro-25	setembro-25
Incc	1.222,356	1.218,747	1.218,747		
LVS	setembro-25	setembro-25	agosto-25		
Indiretos	setembro-25	setembro-25	agosto-25		
Base de Preço	LPU 96	LPU 96	LPU 95		
Takt	2x2	2x2	2x2		
Prazo (mês)	27	27	28	22	24
CUSTO TOTAL I	R$ / UND R$ 107.041	R$ / UND R$ 107.808	R$ / UND R$ 109.161	R$ / UND R$ 105.568	R$ / UND R$ 101.257
Indireto	R$ 19.513	R$ 19.513	R$ 19.476	R$ 19.906	R$ 18.999
Torre	R$ 66.331	R$ 66.658	R$ 68.217	R$ 66.223	R$ 63.681
Infra	R$ 10.788	R$ 10.788	R$ 10.356	R$ 8.809	R$ 10.307
Fundação	R$ 6.929	R$ 6.929	R$ 6.993	R$ 8.672	R$ 7.543
EEE	R$ 474	R$ 474	R$ 474		
ETE					
Contenção	R$ 2.562	R$ 3.002	R$ 3.090	R$ 847	R$ 90
Terraplenagem	R$ 445	R$ 445	R$ 555	R$ 1.110	R$ 638
CUSTO TOTAL II	R$ 6.761	R$ 6.761	R$ 9.556	R$ 707	
Urbanização	R$ 71	R$ 71	R$ 127		
Drenagem	R$ 126	R$ 126	R$ 85		
Extensão de Rede Elétrica	R$ 188	R$ 188	R$ 188		
Extensão de Rede Hidráulica	R$ 6.376	R$ 6.376	R$ 9.156	R$ 707	
CUSTO TOTAL III					
Incorridos					
CUSTO TOTAL IV					
Aprendizado					
CUSTO TOTAL IV		R$ 339	R$ 352		
Atualização por INCC		R$ 339	R$ 352		
CUSTO TOTAL I+II	R$ 113.802	R$ 114.569	R$ 118.717	R$ 106.275	R$ 101.257
CUSTO TOTAL I AO IV	R$ 113.802	R$ 114.908	R$ 119.069	R$ 106.275	R$ 101.257

Custo de Construção

	VILA BUTANTÃ R01	VILA BUTANTÃ R00	
Torres	3	3	
Unidades Construídas	808	808	
Unidades Vendidas	796	796	
Condomínios (qta.)	1	1	
Cidade	São Paulo - SP	São Paulo - SP	
Produto / Selo	F2EPlus - V0200 CDW	F2EPlus - V0200 CDW	
Tipologia	1 Torre | T+25 | 12PP	1 Torre | T+25 | 12PP	
Tipologia	1 Torre | T+23 | 12PP	1 Torre | T+23 | 12PP	
Tipologia	1 Torre | T+25 | 08PP	1 Torre | T+25 | 08PP	
Atributos	150 Varandas	150 Varandas	
Projeto Infra	ED	ED	
Projeto Torre	ED	ED	
Mês Base	dezembro-25	novembro-25	
Incc	1222,356	1218,747	
LVS	setembro-25	setembro-25	
Indiretos	setembro-25	setembro-25	
Base de Preço	LPU 96	LPU 96	
Takt	2x2	2x2	
Prazo (mês)	27	27	
CUSTO TOTAL I	R$ / UND R$ 107.041	R$ / UND R$ 107.808	DIF -R$ 766
Indireto	R$ 19.513	R$ 19.513	R$ 0
Torre	R$ 66.331	R$ 66.658	-R$ 327
Infra	R$ 10.788	R$ 10.788	R$ 0
Fundação	R$ 6.929	R$ 6.929	R$ 0
EEE	R$ 474	R$ 474	R$ 0
ETE	R$ 0	R$ 0	R$ 0
Contenção	R$ 2.562	R$ 3.002	-R$ 440
Terraplenagem	R$ 445	R$ 445	R$ 0
CUSTO TOTAL II	R$ 6.761	R$ 6.761	R$ 0
Urbanização	R$ 71	R$ 71	R$ 0
Drenagem	R$ 126	R$ 126	R$ 0
Extensão de Rede Elétrica	R$ 188	R$ 188	R$ 0
Extensão de Rede Hidráulica	R$ 6.376	R$ 6.376	R$ 0
CUSTO TOTAL III	R$ 0	R$ 0	
Incorridos	R$ 0	R$ 0	R$ 0
CUSTO TOTAL IV	R$ 0	R$ 0	
Aprendizado	R$ 0	R$ 0	R$ 0
CUSTO TOTAL IV	R$ 0	R$ 339	
Atualização por INCC	R$ 0	R$ 339	-R$ 339
CUSTO TOTAL	R$ 113.802	R$ 114.908	-R$ 1.106



OUTROS
-327 | Elevador
-440 | Contenção

INCC
-339 | Atualização de INCC

Custo de Construção

	VILA BUTANTÃ R01	VILA BUTANTÃ PARAMETRIZAÇÃO R09	
Torres	3	3	
Unidades Construídas	808	808	
Unidades Vendidas	796	796	
Condomínios (qta.)	1	1	
Cidade	São Paulo - SP	São Paulo - SP	
Produto / Selo	F2EPlus - V0200 CDW	F2EPlus - V0200 CDW	
Tipologia	1 Torre | T+25 | 12PP	1 Torre | T+25 | 12PP	
Tipologia	1 Torre | T+23 | 12PP	1 Torre | T+23 | 12PP	
Tipologia	1 Torre | T+25 | 08PP	1 Torre | T+25 | 08PP	
Atributos	150 Varandas	150 Varandas	
Projeto Infra	ED	AP	
Projeto Torre	ED	AP	
Mês Base	dezembro-25	outubro-25	
Incc	1222,356	1218,747	
LVS	setembro-25	agosto-25	
Indiretos	setembro-25	agosto-25	
Base de Preço	LPU 96	LPU 95	
Takt	2x2	2x2	
Prazo (mês)	27	28	
CUSTO TOTAL I	R$ / UND R$ 107.041	R$ / UND R$ 109.161	DIF -R$ 2.120
Indireto	R$ 19.513	R$ 19.476	R$ 37
Torre	R$ 66.331	R$ 68.217	-R$ 1.886
Infra	R$ 10.788	R$ 10.356	R$ 432
Fundação	R$ 6.929	R$ 6.993	-R$ 64
EEE	R$ 474	R$ 474	R$ 0
ETE	R$ 0	R$ 0	R$ 0
Contenção	R$ 2.562	R$ 3.090	-R$ 528
Terraplenagem	R$ 445	R$ 555	-R$ 111
CUSTO TOTAL II	R$ 6.761	R$ 9.556	-R$ 2.795
Urbanização	R$ 71	R$ 127	-R$ 56
Drenagem	R$ 126	R$ 85	R$ 41
Extensão de Rede Elétrica	R$ 188	R$ 188	R$ 0
Extensão de Rede Hidráulica	R$ 6.376	R$ 9.156	-R$ 2.780
CUSTO TOTAL III	R$ 0	R$ 0	
Incorridos	R$ 0	R$ 0	R$ 0
CUSTO TOTAL IV	R$ 0	R$ 0	
Aprendizado	R$ 0	R$ 0	R$ 0
CUSTO TOTAL IV	R$ 0	R$ 352	
Atualização por INCC	R$ 0	R$ 352	-R$ 352
CUSTO TOTAL	R$ 113.802	R$ 119.069	-R$ 5.267

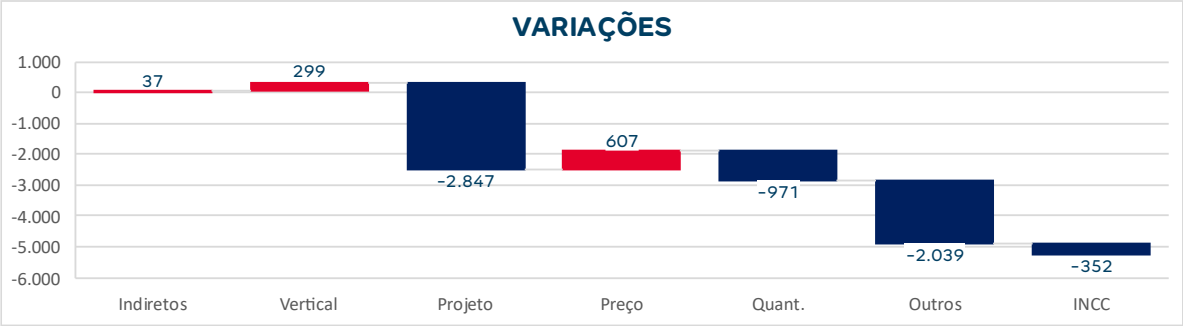

VERTICAL
+299 | Retroalimentação

PROJETO
-111 | Terraplenagem
-124 | Fundação dos anexos infra
-2.332 | Extensão de rede hidráulica
+391 | Vala c/ blindado

PREÇO
+205 | Anexos Infra
-448 | Extensão de rede hidráulica

QUANTIDADE
-660 | Taxa de bombeamento
-227 | Concreto Torre

OUTROS
-992 | Inst. Torre

INCC
-352 | Atualização de INCC

Operações

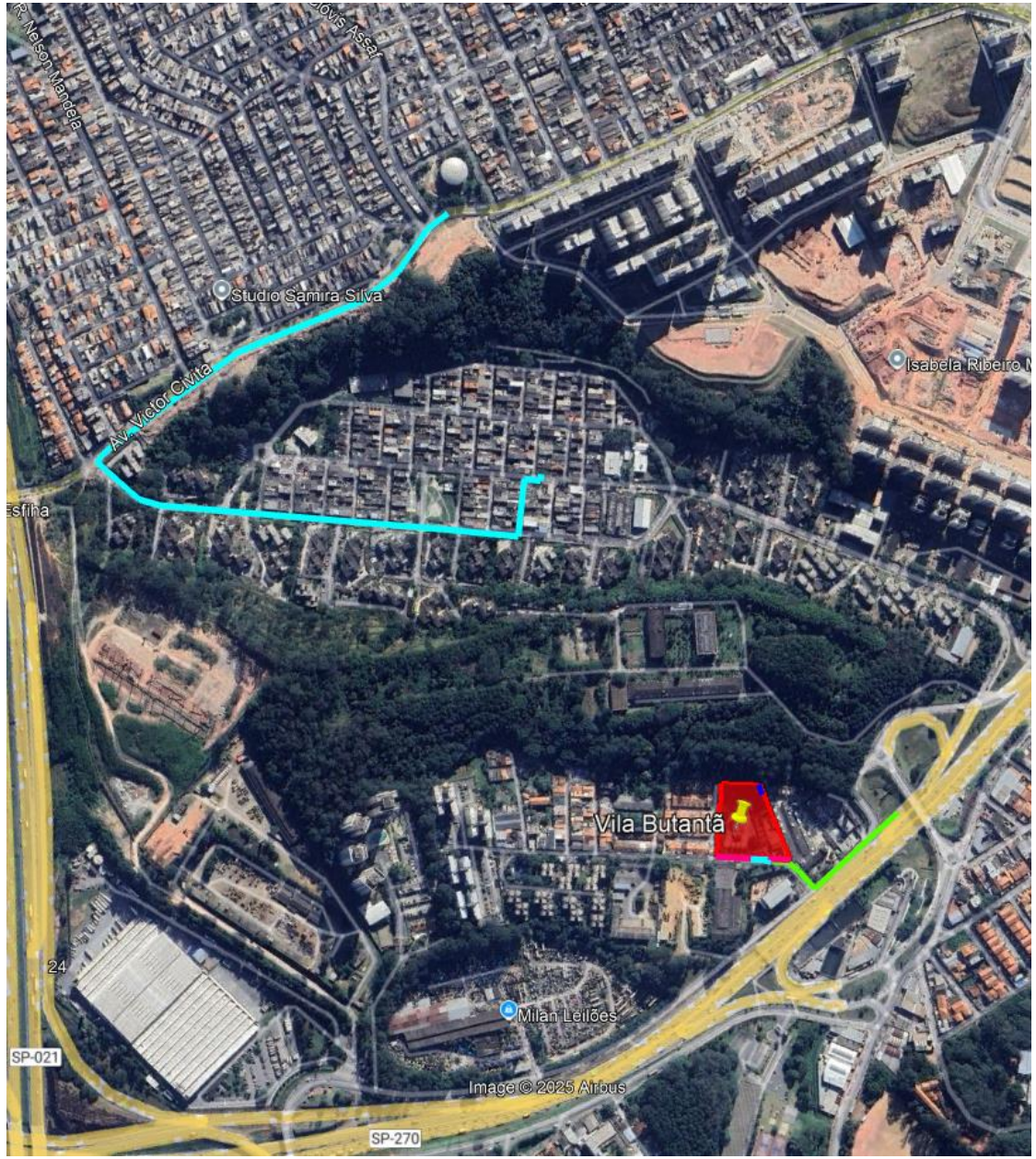

SISTEMA DE ABASTECIMENTO DE ÁGUA
Será realizada extensão de rede de aproximadamente 560m de ø500mm na Av. Vitor Civita + 650m de ø250mm interligando a Rua Cachoeira do Arrependido até a Rua Cachoeira Poraquê.

SISTEMA DE ESGOTAMENTO SANITÁRIO
Para a interligação do empreendimento ao sistema de esgotamento sanitário da Sabesp, deverá ser substituída a rede de 150mm por 300mm em PVC (por gravidade) da frente do empreendimento até a Rodovia Raposo Tavares, com cerca de 230m.

SISTEMA DE DRENAGEM
FNA de drenagem.

SISTEMA DE ABASTECIMENTO DE GÁS
Empreendimento com GN.

SISTEMA DE ABASTECIMENTO ELÉTRICO
Sem viabilidade técnica.

TERRENO

URBANIZAÇÃO
Considerado calçada na testada do empreendimento.

Operações

Matriz Risco Concessionária	
Água	Nível 3
Esgoto	Nível 3
Drenagem	Nível 3
Elétrica	Nível 5
Gás	NA
Urbanização	NA

LEGENDA		
Nível	Tipo	Status
1	Com Diretriz	Conclusiva
2		Conclusiva com projeto aprovado
3		Conclusiva sem projeto aprovado
4		Não Conclusiva
5	Sem Diretriz	-
NA	-	Não aplicável

Água:
- Diretriz emitida em 06/2025, com validade em 06/2027.

Esgoto:
- Diretriz emitida em 06/2025, com validade em 06/2027.

Elétrica:
- Viabilidade existente considera 793uh. Expectativa de recebimento de viabilidade considerando as 796uh em 20/12. De qualquer modo, temos parecer de fornecedor responsável assegurando que essa diferença não influencia.

Drenagem:
- FNA de drenagem no fundo do empreendimento.

Gás:
- Empreendimento com GN.

Urbanização:
- Considerado calçada na testada do empreendimento.

Logística

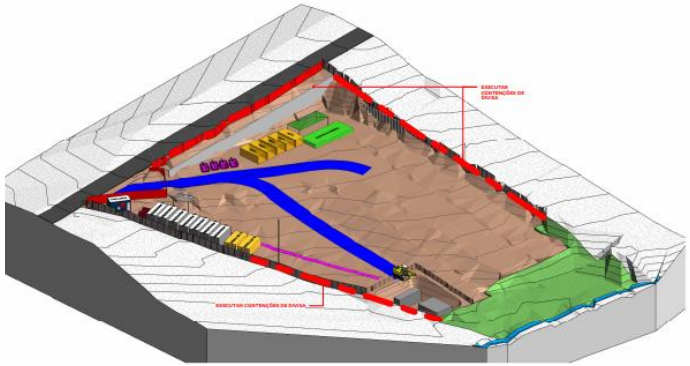

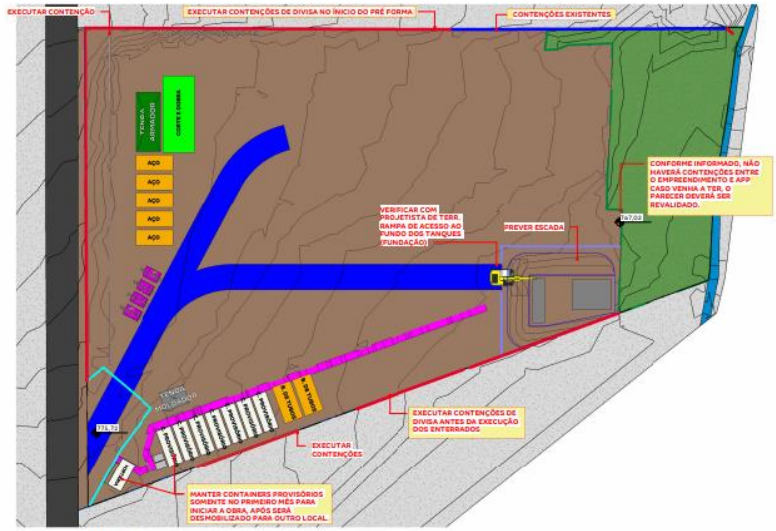

PRÉ FORMA 01
1 : 500

LOG_EQUIPAMENTOS E MAQUINÁRIOS							
EQUIPAMENTO	QUANTIDADE	MOBILIZAÇÃO	DESMOBILIZAÇÃO	PRÉ FORMA	ESTRUTURA	ACABAMENTO	FASE
BETONEIRA (LOG)	VARIÁVEL	-	-	TODO PERÍODO	TODO PERÍODO	-	
BOBCAT (LOG)	1 EQUIPAMENTO	1 MOBILIZAÇÃO	1 DESMOBILIZAÇÃO	-	TODO PERÍODO	CONSIDERAR 15 DIAS DO PERÍODO DE ACABAMENTO	
BOMBA ESTACIONÁRIA PADRÃO (LOG)	1 EQUIP PARA O BLOCO X	-	-	-	TODO PERÍODO	-	
CAMINHÃO MUNCK (LOG)	1 EQUIPAMENTO	1 MOBILIZAÇÃO	1 DESMOBILIZAÇÃO	-	CONSIDERAR MEIO PERÍODO DE ESTRUTURA	-	
CREMALHEIRA CABINE DESMONTÁVEL (LOG)	<varia>	<varia>	<varia>	<varia>	<varia>	<varia>	
CREMALHEIRA CDW (LOG)							
ESCAVADEIRA (LOG)	1 EQUIPAMENTO	1 MOB	1 DESMOB	CONSIDERAR DURANTE O PERÍODO DE TERRAPLENAGEM	-	-	
GUINDASTE (LOG)	1 EQUIPAMENTO PARA IÇAMENTO DOS CASTELOS	1 MOBILIZAÇÃO	1 DESMOBILIZAÇÃO	-	-	-	
MINIGRUA (LOG)	AJUSTAR	1 MOB POR MINIGRUA POR TORRE (TAKT 2X2)	1 DESMOB POR MINIGRUA POR TORRE (TAKT 2X2)	-	TODO PERÍODO	-	
PERFURATRIZ (LOG)		1 MOBILIZAÇÃO	1 DESMOBILIZAÇÃO	CONSIDERAR PERÍODO DE ESTACA CONFORME PROJETO.	-	-	

VIVÊNCIA - CONTAINERS								
DESCRIÇÃO	QUANTIDADE	TAMANHO MÓDULOS	MOBILIZAÇÃO	DESMOBILIZAÇÃO	PRÉ FORMA	ESTRUTURA	ACAB.	FASE
CONTAINER PORTARIA (LOG)	CONSIDERAR 1 MÓDULO DE CONTAINER	2,41m X 4,90m	1 MOB	1 DESMOB	TODO PERÍODO	**AJUSTAR**	**AJUSTAR**	
CONTAINER PROVISÓRIO (LOG)	CONSIDERAR 8 MÓDULOS DE CONTAINER	2,41 X 6,10 m	1 MOB	1 DESMOB	TODO PERÍODO	-	-	
CONTAINER VIVÊNCIA MODULAR (LOG)	1 MÓDULO DE CONTAINER	2,41 X 6,10 m	1 MOB	1 DESMOB	-	TODO PERÍODO	TODO PERÍODO	

LOG_LAZER							
DESCRIÇÃO	QUANTIDADE	MOBILIZAÇÃO	DESMOBILIZAÇÃO	PRÉ FORMA	ESTRUTURA	ACABAMENTO	FASE
FUMODROMO PEQUENO (LOG)	1	-	-	TODO PERÍODO	TODO PERÍODO	TODO PERÍODO	

TENDAS_PERÍODOS							
DESCRIÇÃO	QUANTIDADE	LARGURA	COMPRIMENTO	PRÉ FORMA	ESTRUTURA	ACABAMENTO	FASE
GAIOLA DE DESMOLDANTE (LOG)	1	4,00	6,00	-	TODO PERÍODO	-	
TENDA ARMADOR (LOG)	1	4,00	7,00	TODO PERÍODO	TODO PERÍODO	-	
TENDA ARMAZENAMENTO (LOG)	2	8,00	8,00	AJUSTAR	AJUSTAR	AJUSTAR	
TENDA EXTRA (LOG)	1	6,16	5,07	AJUSTAR	AJUSTAR	AJUSTAR	

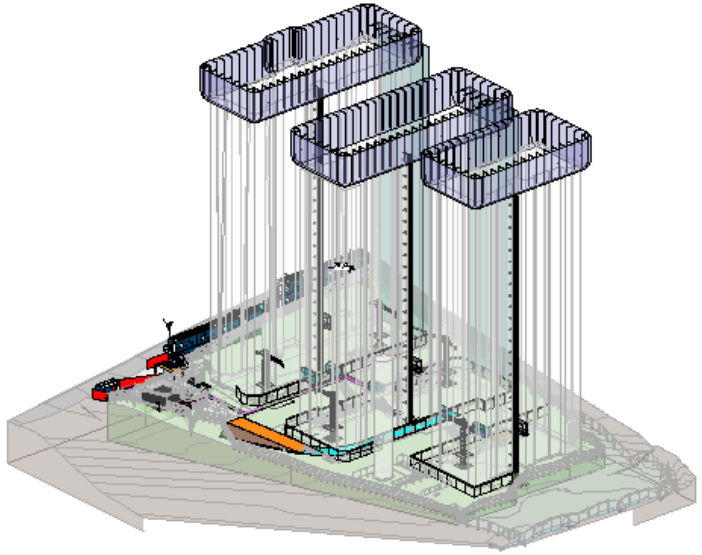

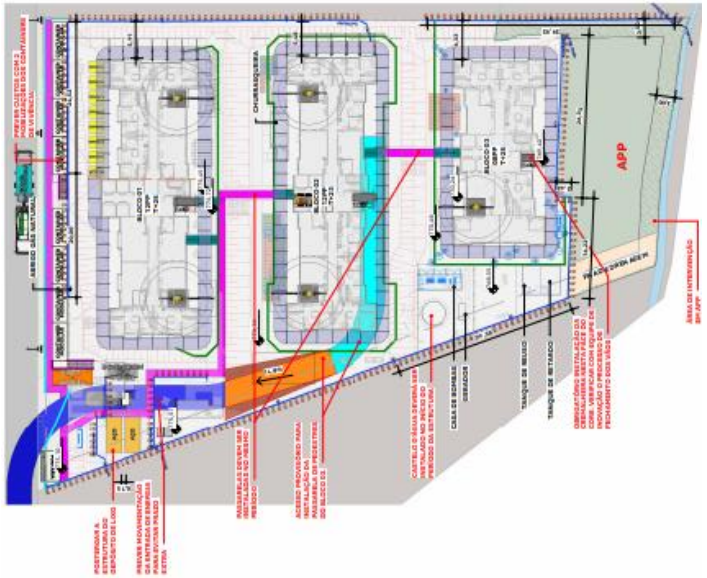

ESTRUTURA E ACABAMENTO
1 : 500

Logística

ITENS A SEREM CONSIDERADOS:

LOG_PRAZO DE OBRA
CONSIDERAÇÕES
CONTENÇÕES DE DIVISA DEVEM SER EXECUTADAS NO INÍCIO DO PERÍODO DE PRÉ FORMA
FUNDAÇÕES DO CASTELO D'ÁGUA DEVEM SER EXECUTADAS NO INÍCIO DO PRÉ FORMA, ANTES DAS FUNDAÇÕES DO BLOCO 03
FNA DE DRENAGEM DEVE SER EXECUTADA NO INÍCIO DO PERÍODO DE PRÉ FORMA

ITENS CRÍTICOS DE PROJETO
OS TRECHOS DE CONTENÇÃO INDICADOS DEVEM SER EXECUTADOS NO INÍCIO DO PERÍODO DE PRÉ FORMA. CONSIDERAR APROXIMADAMENTE 4 MESES DE EXTRA DE PRÉ FORMA.
PREVER CUSTOS COM LOCAÇÃO DE DOIS EQUIPAMENTOS DE FUNDAÇÃO, PARA REDUÇÃO DE PRAZOS NO PERÍODO DE PRÉ FORMA
PREVER MOVIMENTAÇÃO DA ENTRADA DE ENERGIA, QUE ATUALMENTE IMPACTA NO ACESSO DE OBRA, PARA MITIGAR ACRÉSCIMOS DE PRAZO COM EXECUÇÃO E LIGAÇÃO JUNTO À CONCESSIONÁRIA.

PCP 171

SP - Modular 3.0

1 JOGO = **47** Aptos/mês

Empreendimento	Lançto.	Unidades	# jogos	Equipes de forma	Início Obra	Início Forma 1	Início Forma 2	Início Forma 3	Término Forma 1	Término Forma 2	Término Forma 3	Previsão AGI	Folga Inicio	Folga Aptidão	Folga Cliente	Carência CEF
CDW 10 | Oásis Penha	jul/25	672	2	B	01/02/26	16/07/26	16/07/26		18/02/27	18/02/27		nov/27	6,7	1,4	8,1	NC
CDW 15 | Jd dos Prados	ago/25	800	2	G	18/03/26	31/07/26	04/08/26		16/04/27	20/04/27		jan/28	7,2	6,7	7,1	NC
CDW 15 | Alvorada Aricanduva (Sobral)	out/25	577	2	F	01/01/26	30/07/26	17/08/26		02/02/27	20/02/27		nov/27	2,6	1,3	11,2	NC
CDW 15 | Dália	set/25	667	2	F	17/06/26	03/02/27	21/02/27		07/09/27	25/09/27		out/28	9,2	7,3	-1,0	NC
CDW 10 | Panorama Santo André (Adriático)	out/25	646	2	B	30/07/26	19/02/27	19/02/27		16/09/27	16/09/27		jun/28	9,6	-	4,1	NC
CDW 15 | Vila Butantã	fev/26	808	2	G	23/06/26	17/04/27	21/04/27		03/01/28	07/01/28		set/28	4,3	2,3	5,0	NC
CDW 15 | Horizonte Jaraguá	mar/26	514	2	A	04/05/26	14/05/27	16/05/27		27/10/27	29/10/27		jul/28	1,7	-0,4	8,1	NC

Pareceres

Condições do Negócio

Análise da Mancha e Implantação

Operações

Inteligência de Mercado

Financeiro

Anexo

Demanda e Distribuição da Mancha

Potencial de Demanda			Lançados		Lançados + Landbank	
Mancha	CÓD.	Shr.	ANO	MÊS	ANO	MÊS
São Paulo Oeste	SZO	36%	520	43	624	52

Faixas MCMV	Empreendimento	Renda	Lançamento	dez/25	jan/26	fev/26	mar/26	abr/26	mai/26	jun/26	jul/26	ago/26	set/26	out/26	nov/26	dez/26	jan/27	fev/27	mar/27	abr/27	mai/27	jun/27
Faixa 2	Life Jaguaré F1	4.000	set-24	37	37	37	37	37	21													
Faixa 3	Max Vila Sônia	5.341	nov-25	37	37	37	37	37	37	37	37	37	37	37	37	37	37	37	37	37	37	5
Faixa 2	**Vila Butantã**	**3.700**	**dez-25**		**45**	**45**	**45**	**45**	**45**	**45**	**45**	**45**	**45**	**45**	**45**	**45**	**45**	**45**	**45**	**45**	**45**	**31**
Faixa 2	Farol Jaguaré I - F2	3.817	abr-26						38	38	38	38	38	38	38	38	38	38	38	38	38	38
Faixa 2	Essence Butantã	4.224	ago-26										23	23	23	23	23	23	23	23	23	23
Total de Vendas Lançados				**37**	**37**	**37**	**37**	**37**	**21**	**0**	**0**	**0**	**0**	**0**	**0**	**0**	**0**	**0**	**0**	**0**	**0**	**0**
Total de Vendas Lançados + Landbank				**74**	**119**	**119**	**119**	**119**	**141**	**120**	**120**	**120**	**143**	**143**	**143**	**143**	**143**	**143**	**143**	**162**	**162**	**116**
Total Mancha | Faixa 1				0%	0%	0%	0%	0%	0%	0%	0%	0%	0%	0%	0%	0%	0%	0%	0%	0%	0%	0%
Total Mancha | Faixa 2				50%	69%	69%	69%	69%	74%	69%	69%	69%	74%	74%	74%	74%	74%	74%	74%	65%	65%	79%
Total Mancha | Faixa 3				50%	31%	31%	31%	31%	26%	31%	31%	31%	26%	26%	26%	26%	26%	26%	26%	35%	35%	21%

Apesar de o total de unidades previsto para a mancha ser maior que o potencial de demanda calculado por I.M, não devemos ter problemas com VSO, pois os projetos Max Vila Sônia, Villa Butantã e Life Jaguaré estão na divisa com outras manchas e devem capturar demanda dessas regiões. O mapa de origem do slide seguinte evidência esse efeito nos produtos Life Jaguaré e Safira (Empreendimento de 2022 que atuou na mesma região do Villa Butantã).

Parecer de I.M sobre a mancha:

O projeto analisado em comitê está em linha com o potencial teórico de demanda calculado para a mancha. (Total Lançados)

Canibalização:

Sem Risco de Canibalização

Mapa de Origem

Conforme mencionado no slide anterior, os empreendimentos localizados na zona oeste, especialmente aqueles situados em regiões limítrofes, tendem a captar demanda proveniente de áreas vizinhas, comportamento evidenciado nos mapas abaixo. Observa-se que aproximadamente 63% dos clientes do Safira, projeto localizado na mesma região do Vila Butantã, são oriundos de manchas adjacentes. O mesmo padrão se repete no Life Jaguaré, referência atual da mancha, cujas 73% das vendas também se originam de regiões vizinhas.

Safira (2021/2022)

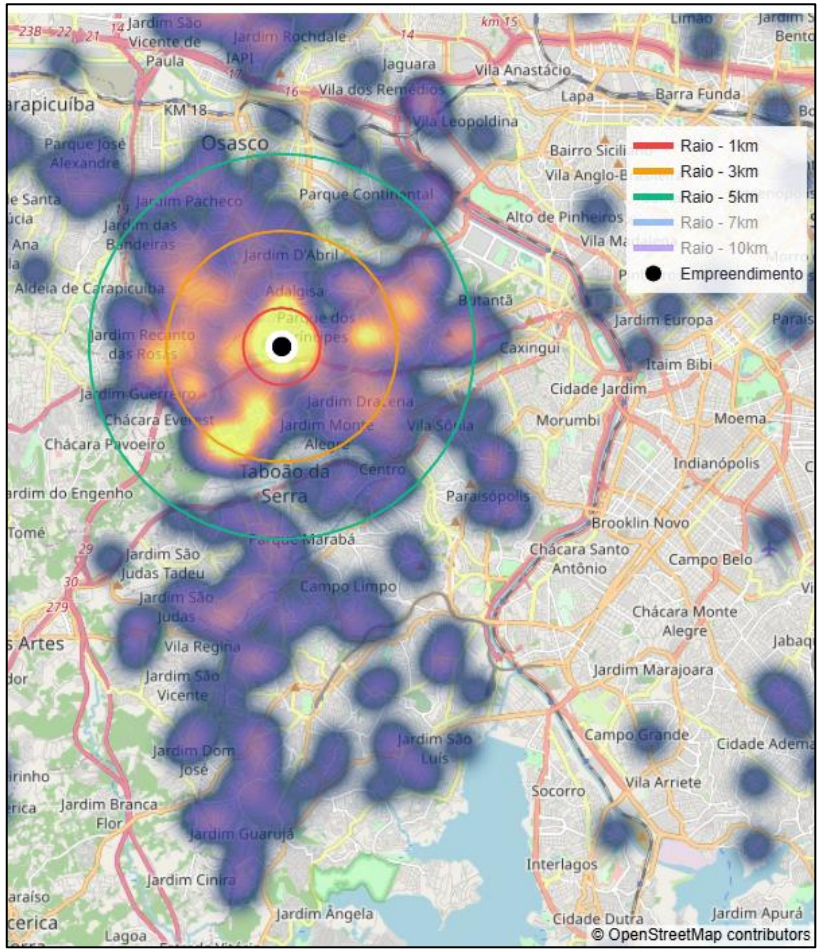

Life Jaguaré (2024/2025)

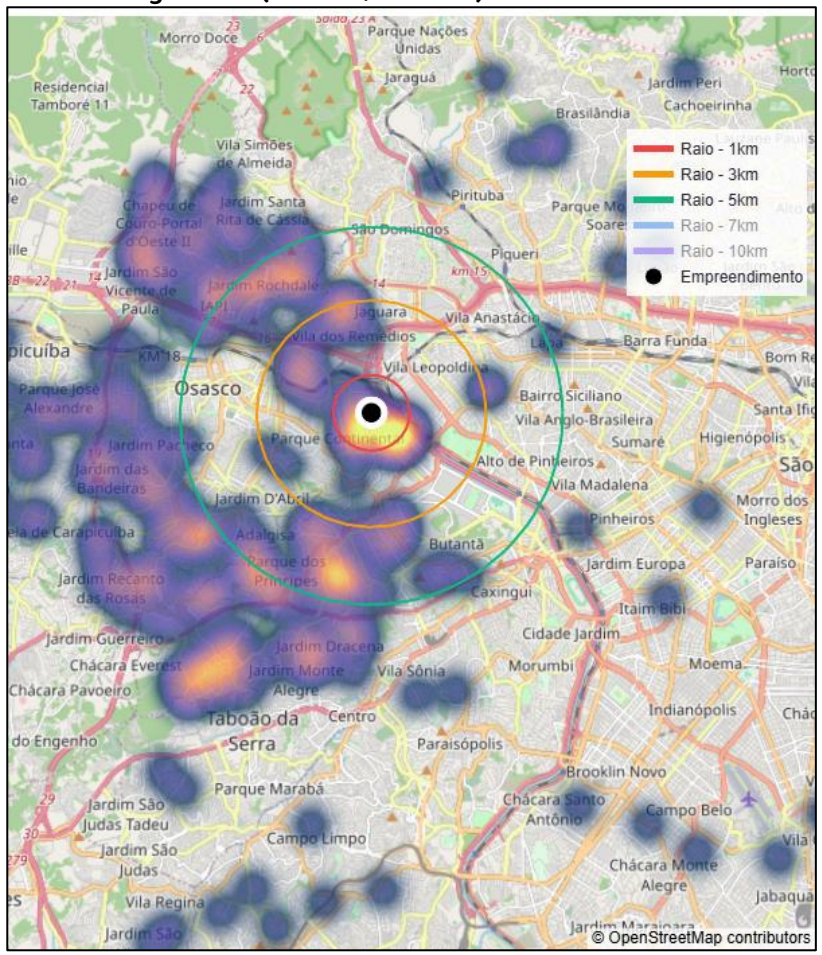

Projeto	Região	% Compradores
Safira	Zona Oeste	37%
	Demais Regiões	63%
Life Jaguaré	Zona Oeste	27%
	Demais Regiões	73%

Vila Butantã | Mapa Concorrência

		Vila Butantã	Conquista Clube Butantã	Quatro Estações Novo Osasco	Residencial Olímpia
		TENDA	Direcional	OZ	MRV
	Distância Tenda (km)		2,3km	2,5km	1,28km
Região 1 Km	População	24.792	27.472	62.822	28.595
	Dens. Demográfica	7.943	8.801	20.126	9.161
	Renda (R$)	5.899	5.394	5.415	5.447
	Classe Social	C1 (2.7k a 4.6k)	C1 (2.7k a 4.6k)	C1 (2.7k a 4.6k)	C1 (2.7k a 4.6k)
	PEA Dia	11.948	16.111	22.450	11.318
Quantitativo	Lançamento	dez/25	10/2024	01/2023	02/2024
	Unidades	796	668	269	408
	Estoque	796	441	109	51
	VSO	45	21	15	19
	Stockout	18	21	7	3
Qualitativo	Condomínios	1	1	1	1
	Torres	3	6	1	2
	Gabarito	T+25 e T+23	T+9	T+16	T+16
	Plantas (m²)	32,69 e 34,46m²	32,34m² e 32,34m²	36m² e 67m²	42,44m² e 39,67m²
	Tipologia	2 Dorms	1 e 2 Dorms	2 Dorms	2 Dorms
	Opções	Não	Não	Garden	Não
	Varanda	Sim	Não	Sim	Não
	Vagas	Sem vaga	Sem Vaga	Com Vaga	Sem vaga
	Lazer	Quadra Descoberta, 2 Churrasqueiras, Salão de Festas Gourmet, Brinquedoteca, Espaço Office, Espaço Teen, Espaço Saúde, Espaço Oficina, Sport Bar, Minimarket, Pet Place, Horta, Play baby, Play kids, Funcional, Multipla Estação, Praça de Jogos, Espaço Relax	Academia ao ar livre, Bar, Bicicletário, Brinquedoteca, Churrasqueria, Coworking, Fitness Center, Lavanderia, Lounge, Mercado, Pet Place, Piscina, Playground, Praça, Quadra Poliesportiva, Salão de Festas, Salão de Jogos,	Tem Garden, Academia ao ar livre, Bicicletário, Brinquedoteca, Churrasqueria, Coworking, Espaço Gourmet, Fitness Center, Pet Place, Piscina, Piscina infantil, Pista caminhada, Playground, Quadra, Redário, Salão de Festas, Salão de Jogos, SPA, Varanda Gourmet,	Bicicletário, Brinquedoteca, Churrasqueria, Espaço Gourmet, Pet Place, Playground, Salão de Festas,

Diagnóstico Concorrência

- A concorrência atua em target de preço e renda superior ao projetado para o Villa Butantã, exceto o 'Conquista Clube Direcional, que prática preços similares, contudo, devido as suas políticas de crédito, precisa capturar clientes de renda mais altas que a do produto Tenda.

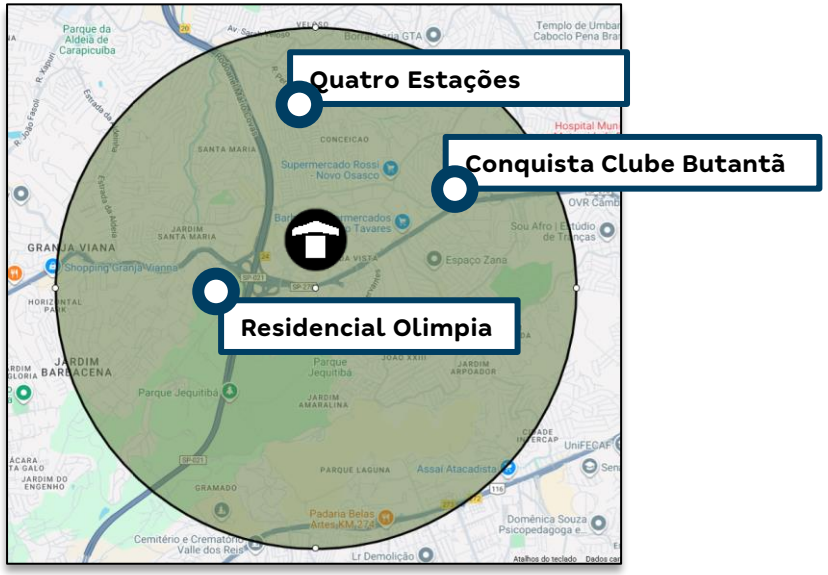

Farol Renda
Acima de 300
Entre 0 e 300
Abaixo de 0

-	Vila Butantã					Conquista Clube Butantã					Quatro Estações Novo Osasco				Residencial Olímpia			
Tipologias	Avaliação	Preço Nominal	CEF	Renda	% Unidades	Avaliação	Preço Nominal	CEF	Renda	Farol	Preço Nominal	CEF	Renda	Farol	Preço Nominal	CEF	Renda	Farol
Faixa 1	-	-	-	-	-	254.000	199.000	159.200	2.850	-	-	-	-	-	-	-	-	-
HIS	263.000	232.764	181.402	3.409	64%	-	-	-	-	-	-	-	-	-	-	-	-	-
HMP	263.000	235.412	185.982	3.579	17%	254.000	241.000	192.800	4.350	●	-	-	-	-	263.990	211.192	4.700	●
Varanda	290.000	259.793	198.817	4.798	19%	-	-	-	-	-	-	-	-	-	-	-	-	-
Vaga Moto	-	-	-	-	-	-	-	-	-	-	262.742	210.194	4.700	-	-	-	-	-
Vaga Carro	-	-	-	-	-						269.647	215.718	5.400	-	-	-	-	-
Garden - Vaga Carro	-	-	-	-	-	-	-	-	-	-	302.477	241.982	6.000	-	-	-	-	-

Simulação de Preço

Informações Viabilidade

Projeto:	Vila Butantã					
Tipo:	**HIS**		**HMP**		**Varanda**	
Método	**Vision**		**Vision**		**Vision**	
Avaliação	263.000		263.000		290.000	
Renda Inicial (VF)	3.409		3.579		4.798	
Renda Final*	-		-		-	
% RET1	25%		25%		0%	
Tipo:	**VF**	**R$**	**VF**	**R$**	**VF**	**R$**
Ato	0,81	2.696	0,81	2.830	0,59	2.749
FGTS	0,76	2.527	0,78	2.718	0,62	2.927
Financiamento	95,45%	172.573	95,70%	178.412	96,54%	195.890
Subsídio	184,13%	6.302	191,39%	4.852	0,00%	0
Prazo de Pró-soluto	31	31	31	31	31	31
Pró-Soluto	70,07%	26.904	70,07%	28.246	70,07%	37.866
Preço Raso (RS)	211.002	211.002	217.058	217.058	239.431	239.431
TCD	63,33%	21.762	50,88%	18.354	42,10%	20.362
VSO	29	29	8	8	8	8
Preço de Venda	**237.716**	**237.716**	**240.421**	**240.421**	**265.320**	**265.320**
Elasticidade	-2,083%	-2,083%	-2,083%	-2,083%	-2,083%	-2,083%
Preço de Venda Final	**232.764**	**232.764**	**235.412**	**235.412**	**259.793**	**259.793**
Preço Raso (R$)	**211.002**		**217.058**		**239.431**	
% de Raso	**90,65%**		**92,20%**		**92,16%**	
BP25 - Não Inflacionado	**-**		**-**		**-**	
BP25 - Inflacionado	**-**		**-**		**-**	

Análise de Preço

Informações Viabilidade

Projeto:	Vila Butantã	
Tipo:	**Faixa 2**	
Método	**Vision**	
Avaliação	268.088	
Renda Inicial (VF)	3.700	
Renda Final*	-	
Tipo:	**VF**	**R$**
Ato	0,77	2.729
FGTS	0,73	2.635
Financiamento	95,70%	177.965
Subsídio	150,67%	4.866
Prazo de Pró-soluto	31	31
Pró-Soluto	70,07%	29.199
Preço Raso (RS)	217.394	217.394
TCD	57,20%	20.916
VSO	45	45
Preço de Venda	**243.274**	**243.274**
Elasticidade	-2,083%	-2,083%
Preço de Venda Final	**238.310**	**238.310**
Preço Raso (R$)	**217.394**	
% de Raso	**91,22%**	
Raso Todas as Fases	**217.394**	
Nominal Todas as Fases	**238.310**	

1

Análise de Riscos	Farol IM
IM avalia o Preço Vision como **factível**, porém, com **ressalvas para o VSO**.	

1) Apesar do incremento de atributos, como a inclusão de varanda, o projeto está localizado em uma área de borda, o que reforça a ressalva de I.M quanto à necessidade de captar rendas mais altas, especialmente considerando o volume projetado para o empreendimento.

Ainda assim, conforme demonstrado no slide "Panorama de Concorrência", os projetos da Direcional e da MRV na mesma região têm conseguido capturar rendas elevadas, inclusive em unidades sem varanda. Esse comportamento de mercado oferece maior segurança e respaldo ao parecer projetado para o Vila Butantã.

	Preço Real					Preço Norm. (31m)	
	Avaliação	Preço Raso	Renda Med	VSO	PSOL	Δ PSOL	Preço Raso
Vila Butantã	268.088	217.394	3.700	45	31	-	217.394
Life Jaguaré	232.925	200.059	3.811	39	15	16.032	216.091

Ciclo Financeiro – Análise Mancha

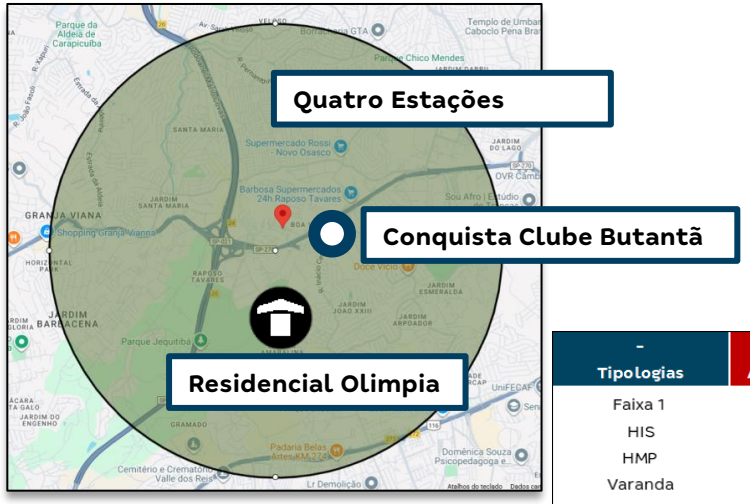

-	Vila Butantã					Conquista Clube Butantã					Quatro Estações Novo Osasco				Residencial Olímpia			
Tipologias	Avaliação	Preço Nominal	CEF	Renda	% Unidades	Avaliação	Preço Nominal	CEF	Renda	Farol	Preço Nominal	CEF	Renda	Farol	Preço Nominal	CEF	Renda	Farol
Faixa 1	-	-	-	-	-	254.000	199.000	159.200	2.850	-	-	-	-	-	-	-	-	-
HIS	263.000	230.609	180.814	3.409	64%	-	-	-	-	-	-	-	-	-	-	-	-	-
HMP	263.000	235.188	183.525	3.579	18%	254.000	241.000	192.800	4.350	●	-	-	-	-	263.990	211.192	4.700	●
Varanda	290.000	259.205	198.229	4.798	18%	-	-	-	-	-	-	-	-	-	-	-	-	-
Vaga Moto	-	-	-	-	-	-	-	-	-	-	262.742	210.194	4.700	-	-	-	-	-
Vaga Carro	-	-	-	-	-						269.647	215.718	5.400	-	-	-	-	-
Garden - Vaga Carro	-	-	-	-	-	-	-	-	-	-	302.477	241.982	6.000	-	-	-	-	-

Parecer Ciclo

O Ciclo validou tanto o preço quanto o VSO como viáveis. Os concorrentes existentes possuem preços mais altos e políticas de créditos mais restritivas, exigindo rendas superiores. Mediante isso e a atuações positivas anteriores na região do Butantã, há confiança em seguirmos com esse projeto pela oportunidade da localização ter alta demanda.

Simulação de Preço- Cenário Aprovação

Informações Viabilidade

Projeto:	Vila Butantã					
Tipo:	**HIS**		**HMP**		**Varanda**	
Método	**Vision**		**Vision**		**Vision**	
Avaliação	263.000		263.000		290.000	
Renda Inicial (VF)	3.409		3.579		4.798	
Renda Final*	-		-		-	
% RET1	25%		25%		0%	
Tipo:	**VF**	**R$**	**VF**	**R$**	**VF**	**R$**
Ato	0,81	2.696	0,81	2.830	0,59	2.749
FGTS	0,58	2.527	0,61	2.718	0,50	2.927
Financiamento	95,45%	172.573	94,78%	178.412	96,25%	195.890
Subsídio	184,13%	6.302	191,39%	4.852	0,00%	0
Prazo de Pró-soluto	33	33	33	33	33	33
Pró-Soluto	70,07%	28.640	70,07%	30.068	70,07%	40.309
Preço Raso (RS)	212.737	212.737	218.880	218.880	241.874	241.874
TCD	58,77%	21.762	51,64%	16.523	42,10%	20.362
VSO	29	29	8	8	8	8
Preço de Venda	**237.289**	**237.289**	**240.053**	**240.053**	**267.215**	**267.215**
Elasticidade	-2,083%	-2,083%	-2,083%	-2,083%	-2,083%	-2,083%
Preço de Venda Final	**234.499**	**234.499**	**235.404**	**235.404**	**262.236**	**262.236**
Preço Raso (R$)	**212.737**		**218.880**		**241.874**	
% de Raso	**90,72%**		**92,98%**		**92,24%**	
BP25 - Não Inflacionado	-		-		-	
BP25 - Inflacionado	-		-		-	

Pareceres

Condições do Negócio

Análise da Mancha e Implantação

Operações

Inteligência de Mercado

Financeiro

Anexo

Cenário Real

Vila Butanta_Aprovação - SP - São Paulo Capital

Datas e Prazos

	Compra	Lançamento	Início Obra	Término Obra	LÇTO até IO	IO até TO	Chaves	LÇTO até Chaves
Consolidado	jun-24							
HMP-V		jan-26	mai-26	set-28	4 meses	28 meses	jan-29	36 meses
HIS2-V		jan-26	mai-26	set-28	4 meses	28 meses	jan-29	36 meses
HIS2		jan-26	mai-26	set-28	4 meses	28 meses	jan-29	36 meses
HIS1		jan-26	mai-26	set-28	4 meses	28 meses	jan-29	36 meses

Terreno e Incorridos

TOTAL (R$ + Perm.):	17,07 MM	**Incorrido Terreno:**	0,00 MM	**Área do Terreno (100%):**	6.000 m²	**Área Líquida do Terreno:**	4.746 m²
Cash:	0,00 MM	**Nº de Parcelas Cash :**	0	**Custo de terreno m²:**	2.845,4	**Custo de terreno m² Área Líquida:**	3.597,2
Permuta Financeira:	17,07 MM (9,00%)			**VaR 25 (R$ mil):**	0	**Fração Terreno/Terreno + Custo Obra (%VGV):**	9,0% / 54,3%
Permuta Física:	0,00 MM (0,00%)			**VaR 26 (R$ mil):**	0	**CA Máx/Proj.**	6,0 / 4,5
Ato / %VGV:	0,00 MM / 0,0%			**Incorrido de Construção:**	0,08 MM	**Incorridos de Incorporação:**	0,05 MM

Vendas

Fases	Nº Pavimentos	Preço Raso Unit.	Qtde	Preço Unit.	Aval. CEF	Cond. Parcela	% Pró-soluto	% TCD
HMP-V	T+25	239.439	144	259.793	290.000	96,5%	70,1%	42,1%
HIS2-V	T+25	239.439	6	259.793	290.000	96,5%	70,1%	42,1%
HIS2	T+25	217.139	136	235.412	263.000	95,7%	70,1%	50,9%
HIS1	T+25	211.010	510	232.764	263.000	95,5%	70,1%	63,3%

Unidades Totais:	796	**Preço Médio:**	238.310	**Renda Média:**	3.700	**ITBI+Emol. Unit. Médio:**	3.698
Unidades Tenda:	796	**Avaliação Média:**	268.088	**Ato:**	2.840 (0,77 Salários)	**Custo do Ciclo Unit.:**	15.001
VSO:	45 Unidades	**VGV Total:**	189.694.430	**FGTS:**	2.719 (0,73 Salários)	**Preço Raso Médio:**	217.414
RET Médio:	3,4%	**VGV Tenda:**	189.694.430	**% em RET 1%:**	20%	**Adc. Tx. de Aceleração Médio:**	750

Construção

Custo Total Unit.:	107.929	**Eventuais:**	4,00%	**Área priv (m²):**	32,00	**Gape / Mês Unit.:**	11,08

Resultado

LI (R$):	**25.943.518**	**LI:**	**19,71%**	**Exposição de Caixa (R$):**	**14.206.672**	**Margem Bruta Econômica:**	**37,13%**
TIR:	**138,69%**	**LI Aprovação:**	**20,00%**	**Ger. Caixa 12 meses (R$):**	**(11.758.574)**	**Margem Bruta REF:**	**40,17%**
Exposição de Caixa:	**7,53%**	**Δ LI:**	**-0,29%**	**Ger. Caixa 24 meses (R$):**	**16.143.360**	**Margem Rasa Econômica:**	**30,21%**
Payback Contingente (21 m):	**19 m/ (-2 m)**	**LI Marginal:**	**19,83%**	**Ger. Caixa Marginal (R$):**	**45.546.851**	**Margem Rasa REF:**	**34,43%**
Payback Consolidado:	**19 meses**					**Margem de Contribuição Econômica:**	**26,09%**

Cenário Real – DRE (Consolidado)

R$ Mil - Valores Nominais - Compra	Vila Butanta_Aprovação		HMP-V		HIS2-V		HIS2		HIS1	
	Nominal	%	Nominal	%	Nominal	%	Nominal	%	Nominal	%
Receita	188.641	100,0%	36.771	100,0%	1.571	100,0%	31.871	100,0%	118.428	100,0%
PIS/COFINS	(3.520)	1,9%	(807)	2,2%	(34)	2,2%	(568)	1,8%	(2.111)	1,8%
Custo Total	(116.377)	62,9%	(21.261)	59,1%	(953)	62,0%	(19.934)	63,7%	(74.228)	63,8%
Custo Terreno	(14.940)	8,1%	(2.912)	8,1%	(124)	8,1%	(2.524)	8,1%	(9.380)	8,1%
Custo Relacionados a Terreno	(1.014)	0,5%	(189)	0,5%	(8)	0,5%	(172)	0,6%	(644)	0,6%
Custos de Incorporação	(2.822)	1,5%	(504)	1,4%	(85)	5,6%	(562)	1,8%	(1.672)	1,4%
Custo de Construção	(97.600)	52,7%	(17.656)	49,1%	(736)	47,9%	(16.675)	53,3%	(62.533)	53,8%
Lucro Bruto Econômico	68.745	37,1%	14.703	40,9%	583	38,0%	11.369	36,3%	42.090	36,2%
Custo para Rateio	-	0,0%	-	0,0%	-	0,0%	-	0,0%	-	0,0%
Lucro Bruto Contábil	68.745	37,1%	14.703	40,9%	583	38,0%	11.369	36,3%	42.090	36,2%
Despesas de Selling	(16.107)	8,7%	(3.711)	10,3%	(153)	10,0%	(2.595)	8,3%	(9.648)	8,3%
Contingência	(4.339)	2,3%	(846)	2,4%	(36)	2,4%	(733)	2,3%	(2.724)	2,3%
Margem de Contribuição	48.299	26,1%	10.146	28,2%	394	25,6%	8.041	25,7%	29.718	25,5%
IR e CSLL	(2.880)	1,5%	(660)	1,8%	(28)	1,8%	(465)	1,5%	(1.727)	1,5%
Margem Líquida	45.419	24,5%	9.486	26,4%	366	23,8%	7.576	24,2%	27.991	24,1%
Lucro Bruto REF Unit.	97.528	40,2%	118.594	44,7%	113.946	43,6%	94.467	39,4%	92.203	38,9%
Lucro Raso REF Unit.	76.268	34,4%	97.825	40,0%	93.690	38,9%	75.897	34,3%	70.075	32,6%

R$ Mil - VPL - Compra	Vila Butanta_Aprovação		HMP-V		HIS2-V		HIS2		HIS1	
	VP	%	VP	%	VP	%	VP	%	VP	%
Receitas	131.602	100,0%	25.566	100,0%	1.131	100,0%	22.412	100,0%	82.493	100,0%
PIS/COFINS	(2.418)	1,8%	(552)	2,2%	(24)	2,2%	(393)	1,8%	(1.448)	1,8%
Custos e Despesas Totais	(103.240)	78,4%	(19.542)	76,4%	(888)	78,5%	(17.571)	78,4%	(65.240)	79,1%
Custo Terreno	(10.148)	7,7%	(1.970)	7,7%	(87)	7,7%	(1.728)	7,7%	(6.363)	7,7%
Custo Relacionados a Terreno	(960)	0,7%	(179)	0,7%	(7)	0,7%	(163)	0,7%	(610)	0,7%
Custos de Incorporação	(2.198)	1,7%	(394)	1,5%	(71)	6,3%	(448)	2,0%	(1.285)	1,6%
Custo de Construção	(72.638)	55,2%	(13.141)	51,4%	(548)	48,4%	(12.411)	55,4%	(46.539)	56,4%
Despesas de Selling	(13.803)	10,5%	(3.112)	12,2%	(142)	12,6%	(2.243)	10,0%	(8.307)	10,1%
Contingência	(1.514)	1,2%	(295)	1,2%	(13)	1,1%	(256)	1,1%	(950)	1,2%
IR e CSLL	(1.979)	1,5%	(452)	1,8%	(20)	1,8%	(322)	1,4%	(1.185)	1,4%
Lucro Imobiliário	25.944	19,7%	5.471	21,4%	219	19,4%	4.448	19,8%	15.805	19,2%

Informações Gerais – Consolidado

Vila Butanta_Aprovação – SP – São Paulo Capital

Datas e Prazos

	Compra	Lançamento	Início Obra	Término Obra	LÇTO até IO	IO até TO	Chaves	LÇTO até Chaves
Consolidado	jun-24							
HMP-V		jan-26	jul-26	nov-28	6 meses	28 meses	jan-29	36 meses
HIS2-V		jan-26	jul-26	nov-28	6 meses	28 meses	jan-29	36 meses
HIS2		jan-26	jul-26	nov-28	6 meses	28 meses	jan-29	36 meses
HIS1		jan-26	jul-26	nov-28	6 meses	28 meses	jan-29	36 meses

Terreno e Incorridos

TOTAL (R$ + Perm.):	17,19 MM	**Incorrido Terreno:**	0,00 MM	**Área do Terreno (100%):**	6.000 m²
Cash:	0,00 MM	**Nº de Parcelas Cash :**	0	**Custo de terreno m²:**	2.864,2
Permuta Financeira:	17,19 MM (9,00%)			**VaR 25 (R$ mil):**	0
Permuta Física:	0,00 MM (0,00%)			**VaR 26 (R$ mil):**	0
Ato / %VGV:	0,00 MM / 0,0%			**Incorrido de Construção:**	0,08 MM

Área Líquida do Terreno:	4.746 m²
Custo de terreno m² Área Líquida:	3.621,0
Fração Terreno/Terreno + Custo Obra (%VGV):	9,0% / 54,0%
CA Máx/Proj.	6,0 / 4,5
Incorridos de Incorporação:	0,05 MM

Vendas

Fases	Nº Pavimentos	Preço Raso Unit.	Qtde	Preço Unit.	Aval. CEF	Cond. Parcela	% Pró-soluto	% TCD
HMP-V	T+25	241.874	144	262.236	290.000	96,2%	70,1%	42,1%
HIS2-V	T+25	241.874	6	262.236	290.000	96,2%	70,1%	42,1%
HIS2	T+25	218.957	136	235.403	263.000	95,7%	70,1%	45,8%
HIS1	T+25	212.746	510	234.500	263.000	95,5%	70,1%	63,3%

Unidades Totais:	796	**Preço Médio:**	239.881	**Renda Média:**	3.700	**ITBI+Emol. Unit. Médio:**	3.712
Unidades Tenda:	796	**Avaliação Média:**	268.088	**Ato:**	2.840 (0,77 Salários)	**Custo do Ciclo Unit.:**	15.100
VSO:	45 Unidades	**VGV Total:**	190.945.136	**FGTS:**	2.719 (0,73 Salários)	**Preço Raso Médio:**	219.296
RET Médio:	3,4%	**VGV Tenda:**	190.945.136	**% em RET 1%:**	20%	**Adc. Tx. de Aceleração Médio:**	750

Construção

Custo Total Unit.:	107.929	**Eventuais:**	4,00%	**Área priv (m²):**	32,00	**Gape / Mês Unit.:**	11,08

Resultado

LI (R$):	**26.081.105**	**LI:**	**20,04%**	**Exposição de Caixa (R$):**	**11.753.283**	**Margem Bruta Econômica:**	**37,10%**
TIR:	**151,42%**	**LI Aprovação:**	**20,00%**	**Ger. Caixa 12 meses (R$):**	**(9.932.307)**	**Margem Bruta REF:**	**40,07%**
Exposição de Caixa:	**6,18%**	**Δ LI:**	**0,04%**	**Ger. Caixa 24 meses (R$):**	**13.453.073**	**Margem Rasa Econômica:**	**30,29%**
Payback Contingente (21 m):	**19 m/ (-2 m)**	**LI Marginal:**	**20,16%**	**Ger. Caixa Marginal (R$):**	**45.864.640**	**Margem Rasa REF:**	**34,45%**
Payback Consolidado:	**19 meses**					**Margem de Contribuição Econômica:**	**26,07%**

DRE (Consolidado)

R$ Mil - Valores Nominais - Compra	Vila Butanta_Aprovação		HMP-V		HIS2-V		HIS2		HIS1	
	Nominal	%	Nominal	%	Nominal	%	Nominal	%	Nominal	%
Receita	190.097	100,0%	37.169	100,0%	1.588	100,0%	31.873	100,0%	119.467	100,0%
PIS/COFINS	(3.547)	1,9%	(815)	2,2%	(35)	2,2%	(568)	1,8%	(2.129)	1,8%
Custo Total	(117.337)	62,9%	(21.446)	59,0%	(961)	61,9%	(20.078)	64,1%	(74.852)	63,8%
Custo Terreno	(15.056)	8,1%	(2.944)	8,1%	(126)	8,1%	(2.524)	8,1%	(9.462)	8,1%
Custo Relacionados a Terreno	(1.058)	0,6%	(197)	0,5%	(8)	0,5%	(180)	0,6%	(673)	0,6%
Custos de Incorporação	(2.832)	1,5%	(505)	1,4%	(86)	5,5%	(563)	1,8%	(1.677)	1,4%
Custo de Construção	(98.392)	52,7%	(17.800)	49,0%	(742)	47,8%	(16.811)	53,7%	(63.040)	53,7%
Lucro Bruto Econômico	69.213	37,1%	14.908	41,0%	592	38,1%	11.227	35,9%	42.486	36,2%
Custo para Rateio	-	0,0%	-	0,0%	-	0,0%	-	0,0%	-	0,0%
Lucro Bruto Contábil	69.213	37,1%	14.908	41,0%	592	38,1%	11.227	35,9%	42.486	36,2%
Despesas de Selling	(16.201)	8,7%	(3.745)	10,3%	(154)	9,9%	(2.595)	8,3%	(9.707)	8,3%
Contingência	(4.372)	2,3%	(855)	2,4%	(37)	2,4%	(733)	2,3%	(2.748)	2,3%
Margem de Contribuição	48.639	26,1%	10.308	28,4%	401	25,8%	7.899	25,2%	30.032	25,6%
IR e CSLL	(2.902)	1,5%	(667)	1,8%	(29)	1,8%	(465)	1,5%	(1.742)	1,5%
Margem Líquida	45.737	24,5%	9.641	26,5%	372	24,0%	7.434	23,7%	28.289	24,1%
Lucro Bruto REF Unit.	97.923	40,1%	119.808	44,7%	115.116	43,7%	93.398	39,0%	92.748	38,8%
Lucro Raso REF Unit.	76.978	34,5%	99.031	40,1%	94.853	39,0%	76.687	34,4%	70.619	32,6%

R$ Mil - VPL - Compra	Vila Butanta_Aprovação		HMP-V		HIS2-V		HIS2		HIS1	
	VP	%	VP	%	VP	%	VP	%	VP	%
Receitas	130.129	100,0%	25.371	100,0%	1.118	100,0%	22.067	100,0%	81.574	100,0%
PIS/COFINS	(2.391)	1,8%	(548)	2,2%	(24)	2,2%	(387)	1,8%	(1.432)	1,8%
Custos e Despesas Totais	(101.657)	78,1%	(19.276)	76,0%	(875)	78,3%	(17.275)	78,3%	(64.230)	78,7%
Custo Terreno	(10.043)	7,7%	(1.956)	7,7%	(86)	7,7%	(1.703)	7,7%	(6.298)	7,7%
Custo Relacionados a Terreno	(986)	0,8%	(184)	0,7%	(8)	0,7%	(167)	0,8%	(627)	0,8%
Custos de Incorporação	(2.178)	1,7%	(391)	1,5%	(70)	6,3%	(444)	2,0%	(1.273)	1,6%
Custo de Construção	(71.130)	54,7%	(12.868)	50,7%	(536)	48,0%	(12.153)	55,1%	(45.573)	55,9%
Despesas de Selling	(13.880)	10,7%	(3.139)	12,4%	(143)	12,8%	(2.242)	10,2%	(8.355)	10,2%
Contingência	(1.482)	1,1%	(290)	1,1%	(12)	1,1%	(248)	1,1%	(931)	1,1%
IR e CSLL	(1.957)	1,5%	(448)	1,8%	(20)	1,8%	(317)	1,4%	(1.172)	1,4%
Lucro Imobiliário	26.081	20,0%	5.546	21,9%	218	19,5%	4.405	20,0%	15.912	19,5%

Comparativo

Comparativo dos Estudos - Consolidado	Compra	Atual	Atual vs Anterior	Δ%
Data Estudo:	junho-24	dezembro-25	18 Meses	N/A
Lançamento:	janeiro-26	janeiro-26	0 Meses	N/A
Uhs:	707	796	89	12,6%
Preço Nominal:	224.431	239.881	15.450	6,9%
Preço Raso:	200.564	219.296	18.732	9,3%
Preço Nominal Inflacionado:	246.974	244.384	(2.590)	-1,0%
Preço Raso Inflacionado:	220.710	223.439	2.729	1,2%
Renda Média:	2.998	3.700	702	23,4%
RET Médio:	0,00%	3,39%	3,4 p.p.	
% em RET 1%:	0,00%	20,29%	20,3 p.p.	
VSO:	40	45	5	12,5%
ITBI/Emol. Inf (Unit)[2]:	0	4.480	4.480	
Avaliação:	220.000	268.088	48.088	21,9%
Prazo construção F1:	24	27	3	12,5%
Prazo de Pró-Soluto F1:	29	33	4	13,8%
Custo Total Inf (Unit):	154.807	147.409	(7.398)	-4,8%
Custo Construção (Unit):	103.556	107.929	4.373	4,2%
Custo Construção Corrigido:	0	107.929	107.929	
Fração de construção:	46,1%	45,0%	-1,1 p.p.	-2,5%
INCC Folha Rosto:	1.101,39	1.222,36	121	11,0%
Custo Terreno Inf:	15.863.795	15.055.716	(808.079)	-5,1%
Custo Relacionados a Terreno (Unit):	792	1.329	538	67,9%
Fração do Terreno[1]:	9,1% / 55,3%	9,0% / 54,0%	-0,1 p.p.	-1,1%
Custo de Incorp. por uh:	4.003	3.557	(446)	-11,1%
ITBI/Emol. Inf (Total)[2]:	1.860.877	3.565.840	1.704.963	91,6%
Custo do Ciclo (Unit):	14.528	15.100	573	3,9%
Lucro Imobiliário:	18,2%	20,0%	1,8 p.p.	10,1%
LI Marginal:	N/A	20,2%	N/A	N/A
Exposição de caixa:	7,9%	6,2%	-1,7 p.p.	-21,3%
TIR:	126,8%	151,4%	24,6 p.p.	19,4%
Margem Bruta REF:	37,9%	40,1%	2,2 p.p.	5,7%
Margem Bruta Econômica:	34,0%	37,1%	3,1 p.p.	9,1%
Margem Rasa REF:	30,5%	34,5%	3,9 p.p.	12,9%
Margem Rasa Econômica:	25,4%	30,3%	4,9 p.p.	19,3%
Margem Contribuição Econômica:	24,9%	26,1%	1,1 p.p.	4,6%
Payback Contingente (Régua 21 m):	18 m/ (-2 m)	19 m/ (-2 m)	1	5,6%
Payback Consolidado:	18 Meses	19 Meses	1 Meses	5,6%

[1] Valor do terreno contratual

[2] ITBI com taxa de Aceleração

Obrigado