Tenda

sua próxima conquista

Comitê Essencial

Regional: Itaquaquecetuba

Projeto: Laranjal

Data Comitê: 15/12/2025

One Page – Laranjal

[1]

Cidade	Itaquaquecetuba	Mancha de demanda	SP - ITA - Itaquaquecetuba
Regional	SPRM	Cluster MPR	1 - Vermelho
Cenário de Aprovação	Aprovação	Tipo de Aprovação	Consolidado
Fase Anterior	N/A		
Tipo de Comitê	Essencial	Versão da VF	Versão 1.0: Dez

[2]

Unidades (Fases)	568 (1)	CA Máx | Proj	5,0 | 2,3
Unidades com Vaga (%)	141 (25%)	Escritura | Lançamento	nov/27 | fev/28
Unidades com Varandas (%)	0 (0%)	Tipologia	F2E Plus - Concreto

[3]

Valor Líquido do Terreno (% VGV)	3290 (3,1%)	Un. Perm. Fís (% Ter)	0 (0,0%)
Cash (Correção)	0 (NA)	%VGV Perm Fin Líquida (% Ter)	3,1% (100,0%)
Valor R$/m²	400	VAR (%VGV)	000 (0,0%)

Custo Construção (%VGV)	61.773 (47,5%)	Indireto Unit.	19.640
Prazo da Obra (meses)	21	Torre Unit.	63.624
Custo Total Unit. | Corrigido (LPU):	108.756 | 109.261 (94)	Infra Unit.	348
Início de Obra	ago-28	Fundação Unit.	9.623

[4]

Preço Nominal Unit.	228.739	VSO	32
Preço Raso Unit.	209.271	Referência	Vision
Avaliação Unit.	236.900	Renda (% em RET 1%)	2.964 (41,1%)

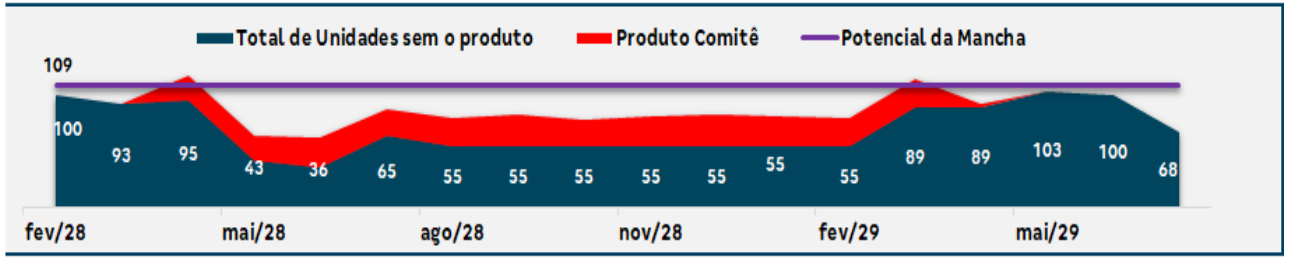

[5]

LI (Régua):	21,8% (20,0%)	Margem Bruta Econômica:	40,2%
LI Resiliência:	7,8% (N/A)	Margem Rasa Econômica:	33,9%
Margem Bruta REF:	43,3%	Margem Contribuição Econômica:	28,6%
Margem Rasa REF:	38,0%	Exposição (% VGV):	16.017 (11,2%)
TIR:	139,4%	VGV Total:	129.924
Payback Contingente (21 m) :	20 m/ (-1 m)	Ger. Caixa 12 meses (R$):	-
Payback Consolidado:	20	Ger. Caixa 24 meses (R$):	(703)

Destaques

[1] Localização: Terreno em **Itaquaquecetuba (RMSP)** e próximo a divisa com Mogi Cruzes. Nosso último empreendimento na cidade foi entregue em 2017 (Veredas de Itaquá).

[2] Implantação: Terreno com área líquida de aprox. 8,2mil m², com implantação de 568 uh (2 torres T+25 – 10pp/12pp) e 23,3% de vagas de carro e 10% de vagas de moto, atendendo a nova legislação; atingimento de 2,27X de CA de um CA máx de 5x (Zeis) – apesar da tipologia T25 o adensamento é dificultado pelas exigência de vagas e pela topografia do terreno.

[3] Condição Comercial:
Valor do Negócio: 3,290 MM – R$ 400/m² e aproximadamente R$ 176/CA (indicadores sobre área líquida)

a) 100% em Permuta financeira com % a ser definido no momento da escritura, com valor líquido e preço mínimo garantido de 3,290 MM equivalente a 400 R$/m². Na viabilidade este valor representa atualmente 3,1% sob a receita bruta e 3,5% sob a líquida (será descontado 12% no fluxo de pagamento, para atingimento do preço líquido de R$ 400/m2);
b) O Preço mínimo garantido (PMG) e líquido equivalente a R$ 400/m² sobre a área líquida, será apurado 30 meses contados do registro de escritura, com correção pelo IPCA com data base da 2ª re
c) Caso atinja o mínimo antes do prazo, continuaremos realizando os pagamentos até a data estabelecida para a quitação do preço;

OBS: o contrato prevê uma condição que consideramos como upside, porém não contemplada na viabilidade.

- Na data de apuração do PMG, se tivermos alguma unidade em estoque, o valor de referência para apuração do PMG será reduzido para R$ 350/m².

d) Garantia: Confissão de dívida

[4] Preço de Venda: Sem lançamentos há 9 anos na região, realizamos estudo com Ciclo e IM: 242k nominal com vaga carro e 222k de raso; 223k nominal sem vaga e 203k de raso. Mesmo assim, permanecemos abaixo do último lançamento MRV (T+4), com preços entre 254k e 229k, respectivamente, em área com infraestrutura inferior (slides 22 e 23).

[5] Resultado: Projeto acima da régua de 20% de LI, com baixa de 70% das unidades.

Pareceres

Análise da Mancha e Implantação

Prospecção

Operações

Incorporação

Inteligência de Mercado

Financeiro

Anexos

Pareceres

Área	Riscos Associados	Parecer	Criticidade
Jurídico	Até o momento não foram identificados apontamentos relevantes que coloquem em risco a aquisição das áreas. Considerando que a aquisição envolve nove imóveis e que, conforme a due diligence preliminar, a soma dos passivos atribuídos tanto a empresa proprietária tabular quanto aos seus sócios representa montante inferior ao valor acordado para a aquisição, entende-se, até o momento, que não há elementos que configurem risco jurídico relevante à transação.	Ok	
Legalização	Apesar de já termos lançado no município anteriormente, a aprovação do novo Plano Diretor e da nova LUOPS nos forçou a reanalisar toda a legislação nova e a termos diversas conversas com as Secretarias de Planejamento e de Habitação sobre o fluxo de aprovações, o que não nos causa preocupação. O processo exige englobamento e desmembramento, ambos sob responsabilidade do proprietário, que terá até 06 meses após a assinatura do contrato para finalização. Quanto à contrapartida financeira, apesar de o regramento legal ainda não estar estabelecido, foi sinalizado um valor aproximado de R$ 273 mil, calculado com base na área total do empreendimento. Considerado aprovação em GRAPROHAB pela ausência de infraestrutura no local.	Ok	
Produto	Sem riscos	Ok	
Inteligência de mercado	Preço Vision como factível	Ok	
Comercial/Ciclo	Preço e VSO factíveis	Ok	
Estudos Econômicos	Sem riscos	Ok	

Pareceres

Análise da Mancha e Implantação

Prospecção

Operações

Incorporação

Inteligência de Mercado

Financeiro

Anexos

Mancha de Demanda

MANCHAS DE DEMANDA • ITA – Itaquaquecetuba
Landbank 1. Cuiabinho 2. Laranjal

Cluster MPR – (Comitê)
Cluster 1 - Vermelho

Região
Metropolitana

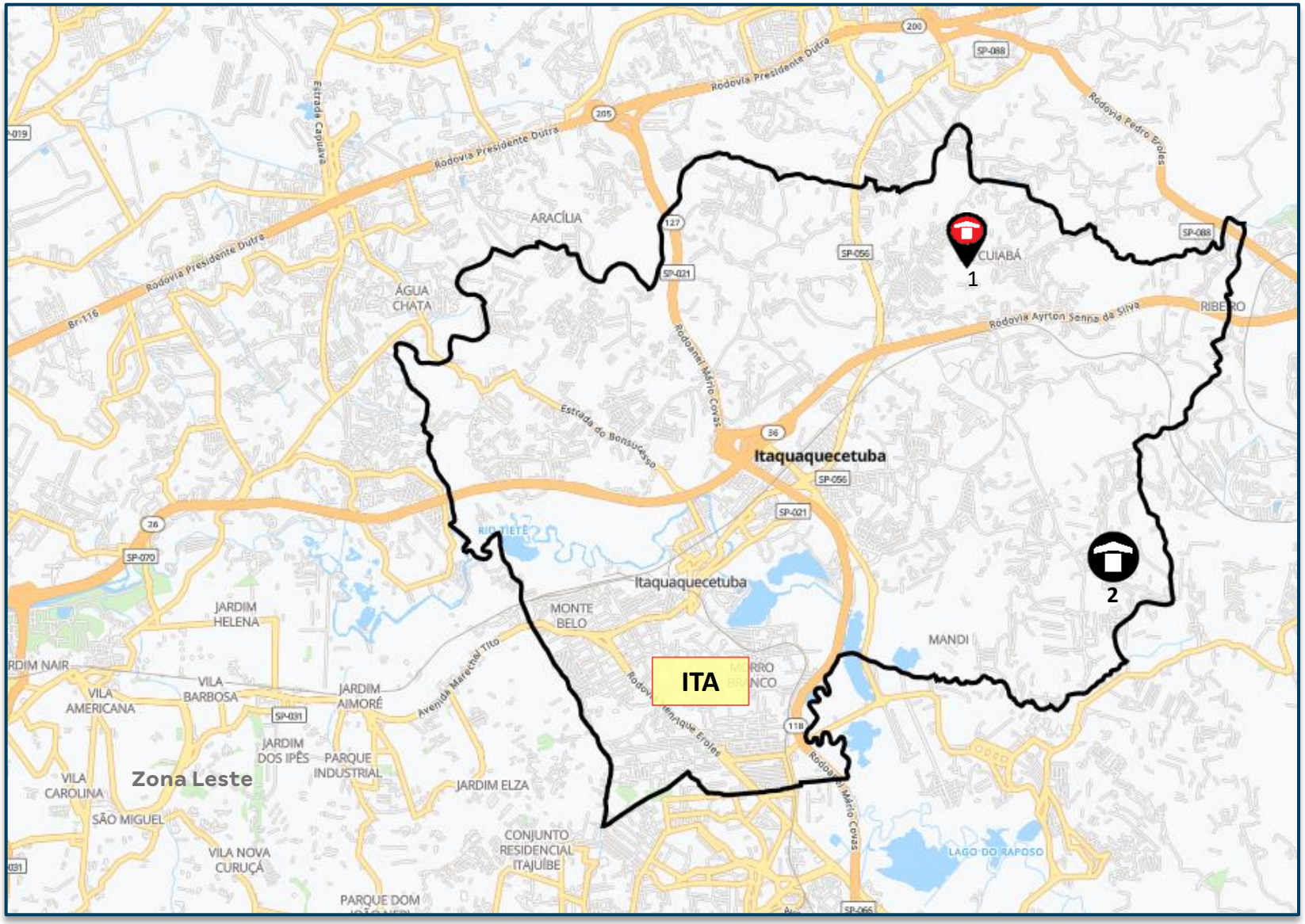

Lançados *LandBank* *Comitê*

Empreendimento Laranjal ITQ Essencial

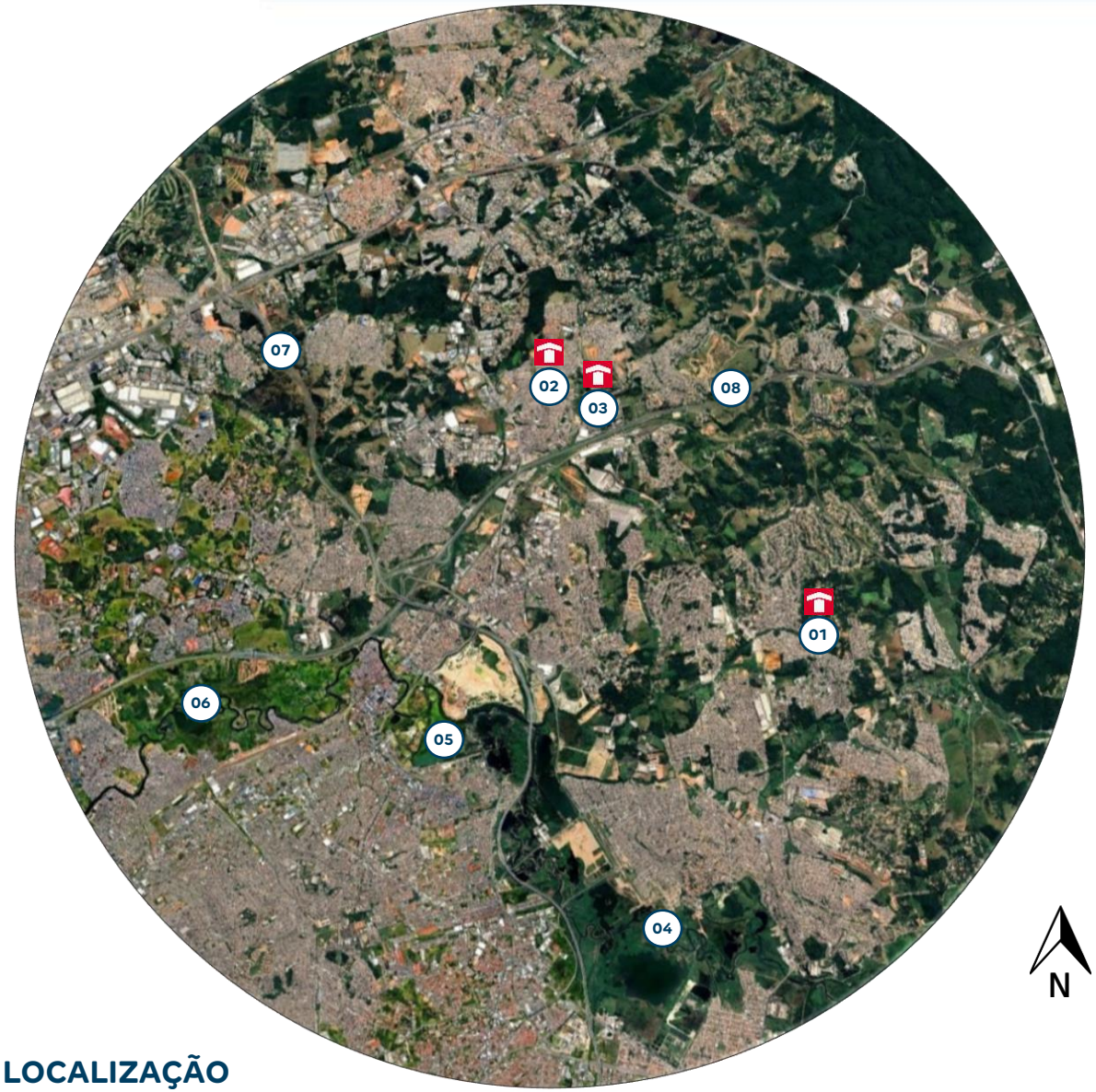

LOCALIZAÇÃO

Legenda:

01 **Laranjal – Itaquaquecetuba**

02 Cuiabinho – Itaquaquecetuba (5,00km)

03 Cuiabão – Itaquaquecetuba (5,30km)

04 Parque do Mirante Professora Bianca Nunes

05 Parque Ecológico Mario do Canto (6,20km)

05 Rio Tietê

07 Rodoanel Mário Covas

08 Rodovia Ayrton Senna

Rua Laranjal

POLIGONAL DO TERRENO

Empreendimento Laranjal ITQ Essencial

LOCALIZAÇÃO

Legenda:

01 **Laranjal**
02 Ponto de Ônibus (0,07km)
03 MK Farma (0,15km)
04 Instituição Educacional - Educandário Vitório Mendes (0,20km)
05 Drogaria Farmed Pium (0,35km)
06 Instituição Educacional – Mário Martins Pereira (0,40km)
07 UBS Recanto Mônica (0,45km)
08 Crás Recanto Mônica/Horto do Ipê (0,60km)
09 Escola de Ensino Fundamental – Euryclides de Jesus Zerbini (0,80km)
10 Centro Médico Público USF – Jardim Margarida (0,90km)
11 Posto Ipiranga (1,05km)
12 Sempre Pinheirinho Novo – Supermercado (1,30km)
13 Creche Subvencionada Maria Crisóstomo da Silva (1,60km)
14 Escola Municipal Professor Alceu Magalhães Coutinho (1,70m)

TERRENO

Rua Laranjal

PRODUTO

Empreendimento Laranjal ITQ Essencial

Informações Gerais – Condomínio Único

Terreno	**Área terreno**	12.371,10m²
	Menor poligonal	8.225,93m²
	Reserva de calçada/ melhoramento viário	Sim (422,66m²)
	Área proprietário (com APP)	1.499,04m² + 2223,47m² (APP)
	Área a ser desmembrada (líquida)	8.225,93m²
Diretrizes Urbanísticas	**Zoneamento**	ZEIS – 2
	Ca máximo Total	5,00
	Ca básico	1
	Ca liquido	2,27
	Ca projetado	2,27
	Gabarito máximo	120,00m
Geral	**Total uh**	568
	Total de vagas exigido	143 (Sendo 133 para carros - 23%, 2 PNE - 2%, 6 para visitantes - 5%, 1 para carga e descarga – 1%, 1 para carga embarque e desembarque – 1%) e 57 para motos - 10%.
	Total de vagas projetado	143 (Sendo 133 para carros - 23%, 2 PNE - 2%, 6 para visitantes - 5%, %, 1 para carga e descarga – 1%, 1 para carga embarque e desembarque – 1%) e 61 para motos - 10%.
Tipologia	**Tipologia**	Modular com elevador
	Gabarito	T+25
	Lâmina	01 10pp e 01 12pp
	Área privativa	32,00m²
Condomínio	**Unidade pcd**	12 (2%)
	Unidade lazer|técnica	02|02
	Torre	02
	Fase	01
Lazer	**Lazer Interno**	03-Salão de festas gourmet , 04 – Brinquedoteca.
	Lazer Externo	01-Salão de festas com churrasqueira, 02-Churrasqueira gourmet.

ÁREA A SER DESMEMBRADA (LÍQUIDA)

ÁREA PROPRIETÁRIO

1. **App:** 2.223,47m².
2. **Córrego Mandi.**
3. **Remanescente do Proprietário:** O acesso ao terreno da APP exigiu a previsão de uma faixa lateral de 13,30 metros de largura.
4. **Melhoramento Viário:** O sistema viário foi adequado para 14 metros.
5. **Área de alta declividade:** Terreno com desnível de 23 m, correspondendo a aproximadamente 17% de inclinação.

PRODUTO

Empreendimento Laranjal ITQ
Essencial

	Descrição	Criticidade	Observação
Usabilidade	**Acesso Empreendimento**		
	Percurso do pedestre até torre		
Diferencial produto	**Faixa de renda**	02	
	Prime	Não	
	Supercondomínio	Não	
	Atributos Infra	Não	
	Atributos Torre	Não	
	Edifício Garagem	Não	
Material Analisado	**KMZ**		
	Base Cartográfica		*Planialtimétrico desenvolvido pela Tenda*
	Matrícula		
Projeto	**Área Liquida**		*A área líquida desconsidera a app, a área remanescente do proprietário e o melhoramento viário.*
	Topografia		*Terreno com desnível de 23 m, correspondendo a aproximadamente 17% de inclinação.*
	Drenagem		*A drenagem será direcionada para o Córrego Mandi, sendo necessária a intervenção em APP para viabilizar a interligação ao curso d'água.*
	Esgoto		*Previsão de ETE em projeto, aguardando diretriz da concessionário para confirmação.*

Pareceres

Análise da Mancha e Implantação

Prospecção

Operações

Incorporação

Inteligência de Mercado

Financeiro

Anexos

Condições do Negócio

➢ VALOR DO NEGÓCIO / CONDIÇÃO COMERCIAL

Valor do Negócio: 3,290 MM – R$ 400/m² e aproximadamente R$ 176/CA (indicadores sobre área líquida)

a) 100% em Permuta financeira com % a ser definido no momento da escritura, com valor líquido e preço mínimo garantido de 3,290 MM equivalente a 400 R$/m². Na viabilidade este valor representa atualmente 3,1% sob a receita bruta e 3,5% sob a líquida (será descontado 12% no fluxo de pagamento, para atingimento do preço líquido de R$ 400/m2);
b) O Preço mínimo garantido (PMG) e líquido equivalente a R$ 400/m² sobre a área líquida, será apurado 30 meses contados do registro de escritura, com correção pelo IPCA com data base da 2ª resolutiva (descrita abaixo);
c) Caso atinja o mínimo antes do prazo, continuaremos realizando os pagamentos até a data estabelecida para a quitação do preço;

OBS: o contrato prevê uma condição que consideramos como upside, porém não contemplada na viabilidade.

- Na data de apuração do PMG, se tivermos alguma unidade em estoque, o valor de referência para apuração do PMG será reduzido para R$ 350/m².

➢ PRAZOS CONTRATUAIS assinado em dez/25

- 1ª Resolutiva: Prazo 4 meses para resolutivas técnica, jurídica e financeira; **(limite abr/26)**
- 2ª Resolutiva: Em até 6 meses da Etapa I para unificação e desmembramento do lote negociado, sob responsabilidade dos vendedores **(limite out/26)**
- 3ª Resolutiva: Em até 18 meses após a superação da Etapa II para aprovação de projeto, contratação CEF, análise técnica, financeira e comercial para e escrituração do terreno. **(limite abr/28)**

➢ GARANTIAS

- Proprietário: Confissão de dívida
- Tenda: N/A

➢ CORRETAGEM

- 4% do valor do negócio a ser pago pela Tenda: R$ 131.600 a ser pago em 1 parcela, após a escritura fixa e irreajustável.

Pareceres

Análise da Mancha e Implantação

Prospecção

Operações

Incorporação

Inteligência de Mercado

Financeiro

Anexos

Custo de Construção – SIMULADOR

PARÂMETROS

Versão: set-25 R00

Empreendimento:	Laranjal			INCC base:	1.216,71
Produto / Selo:	F2E+ Modular	Contenção:	Nível 3	Prazo pré forma:	5,7
Pavimentos Médio:	26	Terraplenagem:	Nível 2	Prazo forma:	5,9
Torres:	2	Varanda %:	0%	Prazo pós Forma:	9,0
PPs médio:	11,0	Piscina:	Não	Prazo total:	21,0
Unidades Construídas:	572	ETE:	Sim	EEE:	Não

Infra Externa

Viário (m):	150	Extensão Esgoto (m):	30
Drenagem (m):	30	Extensão Água (m):	50

Obras ref. contenção

Viver Bem - Usp Leste

Viver Mais

Obras ref. Terraplenagem

Duo Vila Matilde

Vila Socorro

Custo de Construção - SIMULADOR

ESTIMATIVA

DADOS DA OBRA		BASES		PRAZOS DE OBRA	
Regional:	SP	Data:	dezembro-25	Pré Forma:	5,7 meses
Endereço:	Rua Laranjal	Revisão:	R00	Estrutura:	5,9 meses
Total de UH:	**572**	LPU:	LPU 94	Pós Forma:	9,0 meses
Total Torres:	2	LVS:	agosto-25	**TOTAL:**	**21,0 meses**
Produtos:	F2E+ Modular	INCC:	1.216,706		
Tipologia:	10PP/12PP T+25			Jogos de Formas:	2
				Takt:	2+2

CUSTOS DE CONSTRUÇÃO

	CUSTO	R$ / UND
CUSTO TOTAL I	**R$ 61.033.126**	**R$ 107.453**
INDIRETO	R$ 11.155.531	R$ 19.640
TORRE	R$ 36.138.446	R$ 63.624
INFRA	R$ 5.877.570	R$ 10.348
FUNDAÇÃO	R$ 5.465.612	R$ 9.623
ETE	R$ 1.428.775	R$ 2.515
EEE	R$ 0	R$ 0
CONTENÇÃO	R$ 501.733	R$ 883
TERRAPLENAGEM	R$ 465.459	R$ 819
CUSTO TOTAL II	**R$ 740.026**	**R$ 1.303**
VIÁRIO	R$ 102.361	R$ 180
DRENAGEM	R$ 65.000	R$ 114
EXTENSÃO ELÉTRICA	R$ 150.000	R$ 264
EXTENSÃO HIDRÁULICA	R$ 422.665	R$ 744
CUSTO TOTAL I + II	**R$ 61.773.152**	**R$ 108.756**
CUSTO TOTAL III	**R$ 0**	**R$ 0**
INCORRIDOS NÃO APROVEITADOS	R$ 0	R$ 0
CUSTO TOTAL I A III	**R$ 61.773.152**	**R$ 108.756**
CUSTO TOTAL I A IV	**R$ 61.773.152**	**R$ 108.756**

Custo de INFRA – SIMULADOR (LPU 89)

CRITÉRIOS DE INPUT DO SIMULADOR

- Viário: considerado trecho em vermelho
- Drenagem: lançamento por gravidade no córrego dos fundos
- Pontos de interligação de água na esquina do empreendimento
- Ponto de ligação de esgoto: tratamento por ETE e lançamento por gravidade no córrego aos fundos

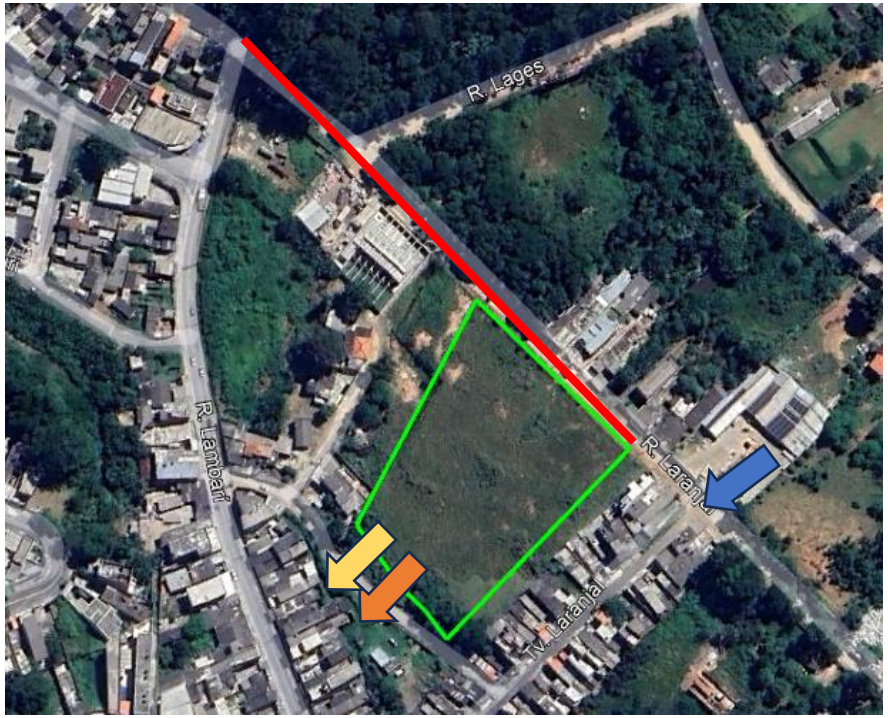

Execução de viário
Ponto de ligação de água
Ponto de ligação de esgoto
Saída da drenagem

Pareceres

Análise da Mancha e Implantação

Prospecção

Operações

Incorporação

Inteligência de Mercado

Financeiro

Anexos

Demanda e Distribuição da Mancha

Potencial de Demanda			Lançados		Lanç + Landbank	
Mancha	CÓD.	Shr.	ANO	MÊS	ANO	MÊS
Itaquaquecetuba	ITA	30%	749	62	898	75

Faixas MCMV	Empreendimento	Renda	Lançamento	fev/28	mar/28	abr/28	mai/28	jun/28	jul/28	ago/28	set/28	out/28	nov/28	dez/28	jan/29	fev/29	mar/29	abr/29	mai/29	jun/29	jul/29	ago/29
Faixa 2	Cuiabinho F1	2.924	jun-27	43	43	43	43	43	43	43	43	43	43	43	2							
Faixa 2	**Laranjal**	**3.064**	**fev-28**		**32**	**32**	**32**	**32**	**32**	**32**	**32**	**32**	**32**	**32**	**32**	**32**	**32**	**32**	**32**	**32**	**32**	**24**
Faixa 2	Cuiabinho F2	2.924	nov-28											20	20	20	20	20	20	20	20	20
Total de Vendas Lançados				**0**	**0**	**0**	**0**	**0**	**0**	**0**	**0**	**0**	**0**	**0**	**0**	**0**	**0**	**0**	**0**	**0**	**0**	**0**
Total de Vendas Lançados + Landbank				**43**	**75**	**75**	**75**	**75**	**75**	**75**	**75**	**75**	**75**	**95**	**54**	**52**	**52**	**52**	**52**	**52**	**52**	**44**
Total Mancha | Faixa 1				*0%*	*0%*	*0%*	*0%*	*0%*	*0%*	*0%*	*0%*	*0%*	*0%*	*0%*	*0%*	*0%*	*0%*	*0%*	*0%*	*0%*	*0%*	*0%*
Total Mancha | Faixa 2				*100%*	*100%*	*100%*	*100%*	*100%*	*100%*	*100%*	*100%*	*100%*	*100%*	*100%*	*100%*	*100%*	*100%*	*100%*	*100%*	*100%*	*100%*	*100%*
Total Mancha | Faixa 3				*0%*	*0%*	*0%*	*0%*	*0%*	*0%*	*0%*	*0%*	*0%*	*0%*	*0%*	*0%*	*0%*	*0%*	*0%*	*0%*	*0%*	*0%*	*0%*

Parecer de I.M sobre a mancha:

O projeto analisado em comitê está acima do potencial teórico de demanda calculado para a mancha. (Total Lanç + Landbank)

Canibalização:

Sem Risco de Canibalização

Laranjal | Mapa Concorrência

		Laranjal	Mirante Da Colina
		TENDA	MRV
	Distância Tenda (km)		3,16Km
Região 1 Km	População	14.931	23.614
	Dens. Demográfica	4.784	7.565
	Renda (R$)	3.457	3.365
	Classe Social	C2 (1.5k a 2.7k)	C2 (1.5k a 2.7k)
	PEA Dia	4.489	6.869
Quantitativo	Lançamento	fev/28	10/2024
	Unidades	568	480
	Estoque	568	166
	VSO	32	24
	Stockout	18	7
Qualitativo	Condomínios	1	1
	Torres	2	12
	Gabarito	0	T+4
	Plantas (m²)	32,93m²	40,82m² e 40,82m²
	Tipologia	2 Dorms	2 Dorms
	Opções	Não	Garden
	Varanda	Não	Não
	Vagas	0%	83% Com vaga
	Lazer	Padrão	Churrasqueira condominial | Elevador social | Espaço gourmet | Pet place | Playground | Portaria | Salão de festas | Segurança

Farol Renda
Acima de 300
Entre 0 e 300
Abaixo de 0

Diagnóstico Concorrência

- O empreendimento da MRV está performando com Target de preço e renda acima do estimado para o Laranjal.

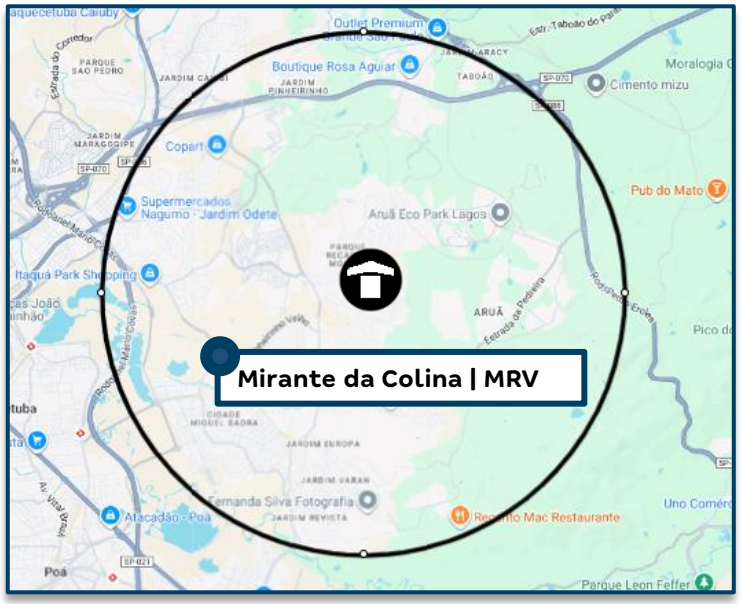

-	Laranjal					Mirante Da Colina				
Tipologias	Avaliação	Preço Nominal	CEF	Renda	% Unidades	Avaliação	Preço Nominal	CEF	Renda	Farol
Uh Tipo	232.750	223.369	176.693	2.803	64%	245.280	229.690	178.351	3.030	●
Vg Moto	238.450	229.331	181.976	3.308	11%					
Vg Carro	247.000	242.422	191.893	3.635	25%	260.000	253.490	197.741	4.050	●
Garden | Vg Carro						285.600	266.890	198.869	4.260	

Simulação de Preço

Informações Viabilidade

Projeto:	Laranjal					
Tipo:	**Uh Tipo**		**Vg Moto**		**Vg Carro**	
Método	**Vision**		**Vision**		**Vision**	
Avaliação	232.750		238.450		247.000	
Renda Inicial (VF)	2.703		3.208		3.535	
Renda Final*	2.803		3.308		3.635	
% RET1	50%		25%		25%	
Tipo:	**VF**	**R$**	**VF**	**R$**	**VF**	**R$**
Ato	0,94	2.626	0,81	2.697	0,73	2.677
FGTS	0,70	1.967	0,59	1.967	0,65	2.387
Financiamento	96,60%	160.225	96,56%	173.853	96,20%	185.607
Subsídio	95,38%	14.501	113,07%	6.155	142,37%	3.899
Prazo de Pró-soluto	26	26	26	26	26	26
Pró-Soluto	96,38%	24.610	82,89%	25.120	84,88%	28.344
Preço Raso (RS)	203.928	203.928	209.793	209.793	222.915	222.915
TCD	71,35%	19.441	60,42%	19.538	54,75%	19.507
VSO	20	20	4	4	8	8
Preço de Venda	**216.164**	**216.164**	**221.933**	**221.933**	**234.602**	**234.602**
Elasticidade	3,333%	3,333%	3,333%	3,333%	3,333%	3,333%
Preço de Venda Final	**223.369**	**223.369**	**229.331**	**229.331**	**242.422**	**242.422**
Preço Raso (R$)	**203.928**		**209.793**		**222.915**	
% de Raso	**91,30%**		**91,48%**		**91,95%**	
BP25 - Não Inflacionado	-		-		-	
BP25 - Inflacionado	-		-		-	

Análise de Preço

Informações Viabilidade

Projeto:	Laranjal
Tipo:	**Faixa 2**
Método	**Vision**
Avaliação	236.900
Renda Inicial (VF)	2.964
Renda Final*	3.064

Tipo:	VF	R$
Ato	0,88	2.646
FGTS	0,68	2.072
Financiamento	96,50%	167.989
Subsídio	108,95%	10.973
Prazo de Pró-soluto	26	26
Pró-Soluto	92,08%	25.592
Preço Raso (RS)	209.271	209.271
TCD	66,06%	19.468
VSO	32	32
Preço de Venda	**221.115**	**221.115**
Elasticidade	3,333%	3,333%
Preço de Venda Final	**228.739**	**228.739**
Preço Raso (R$)	**209.271**	
% de Raso	**91,49%**	
Raso Todas as Fases	**209.271**	
Nominal Todas as Fases	**228.739**	

1

Análise de Riscos	Farol IM
IM avalia o Preço Vision como **factível**.	

1) O projeto está localizado em uma região metropolitana, próximo de pontos de interesses como hospital, escola e etc.

Conforme consta no slide "Panorama de Concorrência", os concorrentes da região vendem em um target de preço e renda acima do previsto para o Produto Tenda.

Abaixo segue o comparativo de preço do Jd. Dos Prados(Tenda), embora ele esteja localizado em outro município(Guarulhos), o projeto está em uma região metropolitana similar.

	Preço Real					Preço Normalizado (26m)	
	Avaliação	Preço Raso	Renda Mediana	VSO	PSOL	Δ PSOL	Preço Raso
Jd. Dos Prados	234.578	210.331	3.114	56	30	-4.766	205.565
Cuiabinho	249.411	204.938	2.924	43	28	-1.913	203.025
Laranjal	236.900	209.271	3.064	32	26	-	209.271

Estudo de Mercado (MRV Mirante da Colina)

PLANTA

- 2 quartos
- Área privativa

As imagens são meramente ilustrativas, buscando representar artisticamente o empreendimento. Móveis, objetos, revestimentos decorativos, equipamentos e demais acabamentos são apenas referências e não fazem parte do contrato de compra e venda da unidade. Consulte o memorial descritivo para obter detalhes sobre as características e materiais a serem entregues no empreendimento. Consulte mais informações no final do material.

PLANTA

- 2 quartos
- Apto. tipo

As imagens são meramente ilustrativas, buscando representar artisticamente o empreendimento. Móveis, objetos, revestimentos decorativos, equipamentos e demais acabamentos são apenas referências e não fazem parte do contrato de compra e venda da unidade. Consulte o memorial descritivo para obter detalhes sobre as características e materiais a serem entregues no empreendimento. Consulte mais informações no final do material.

IMPLANTAÇÃO 3D

IMPLANTAÇÃO

MIRANTE DA COLINA - IMPLANTAÇÃO

ÁREA DE LAZER
1. Salão de festas
2. Gourmet
3. Churrasqueira
4. Playground
5. Espaço kids
6. Pet place
7. Bicicletário
8. Instalações sanitárias lazer

ÁREA DE APOIO
9. Guarita
10. Apoio administrativo
11. Depósito de lixo
12. Castelo d´água
13. Casa de bombas
14. Reservatório de retenção
15. Espaço reservado para equipamento

ACESSOS
- Blocos
- Pedestre
- Veículos
- Serviço

RESIDENCIAL
- Área privativa

Estudo de Mercado

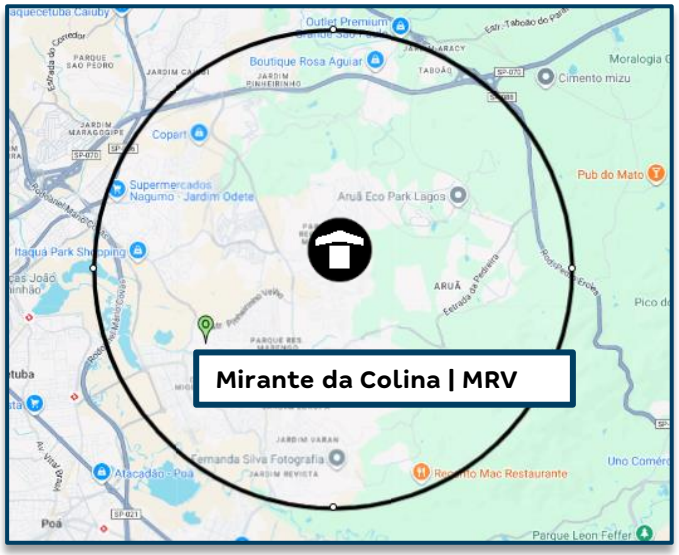

-	Laranjal					Mirante Da Colina				
Tipologias	Avaliação	Preço Nominal	CEF	Renda	% Unidades	Avaliação	Preço Nominal	CEF	Renda	Farol
Uh Tipo	232.750	223.369	176.693	2.803	64%	245.280	229.690	178.351	3.030	●
Vg Moto	238.450	229.331	181.976	3.308	11%					
Vg Carro	247.000	242.422	191.893	3.635	25%	260.000	253.490	197.741	4.050	●
Garden | Vg Carro						285.600	266.890	198.869	4.260	

Parecer do Ciclo

Ciclo avaliou Preço e VSO como factíveis. O projeto está em uma região estratégica na borda de São Paulo, e consolidada com diversos projetos da Tenda e o concorrente possui preço superior ao nosso.

Pareceres

Análise da Mancha e Implantação

Prospecção

Operações

Incorporação

Inteligência de Mercado

Financeiro

Anexos

Informações Financeiras

Laranjal - SPRM - Região Metropolitana > 100mil SP

Datas e Prazos

	Compra	Lançamento	Início Obra	Término Obra	LÇTO até IO	IO até TO	Chaves	LÇTO até Chaves
Consolidado	dez-25							
sem vaga		fev-28	ago-28	mai-30	6 meses	21 meses	fev-31	36 meses
vaga moto		fev-28	ago-28	mai-30	6 meses	21 meses	fev-31	36 meses
vaga carro		fev-28	ago-28	mai-30	6 meses	21 meses	fev-31	36 meses

Terreno e Incorridos

TOTAL (R$ + Perm.):	4,55 MM	Incorrido Terreno:	0,00 MM	Área do Terreno (100%):	12.334 m²	Área Líquida do Terreno:	8.225 m²
Cash:	0,00 MM	Nº de Parcelas Cash :	0	Custo de terreno m²:	368,7	Custo de terreno m² Área Líquida:	552,9
Permuta Financeira:	4,55 MM (3,50%)			VaR 25 (R$ mil):	0	Fração Terreno/Terreno + Custo Obra (%VGV):	3,5% / 51,0%
Permuta Física:	0,00 MM (0,00%)			VaR 26 (R$ mil):	0	CA Máx/Proj.	5,0 / 2,3
Ato / %VGV:	0,00 MM / 0,0%			Incorrido de Construção:	0,00 MM	Incorridos de Incorporação:	0,00 MM

Vendas

Fases	Nº Pavimentos	Preço Raso Unit.	Qtde	Preço Unit.	Aval. CEF	Cond. Parcela	% Pró-soluto	% TCD
sem vaga	T+25	203.928	366	223.369	232.750	96,6%	96,4%	71,4%
vaga moto	T+25	209.793	61	229.331	238.450	96,6%	82,9%	60,4%
vaga carro	T+25	222.915	141	242.422	247.000	96,2%	84,9%	54,7%

Unidades Totais:	568	Preço Médio:	228.739	Renda Média:	2.964	ITBI+Emol. Unit. Médio:	4.663
Unidades Tenda:	568	Avaliação Média:	236.900	Ato:	2.594 (0,88 Salários)	Custo do Ciclo Unit.:	14.399
VSO:	32 Unidades	VGV Total:	129.923.919	FGTS:	2.015 (0,68 Salários)	Preço Raso Médio:	209.271
RET Médio:	2,8%	VGV Tenda:	129.923.919	% em RET 1%:	41%	Adc. Tx. de Aceleração Médio:	750

Construção

Custo Total Unit. | Corrigido:	108.756 | 109.261	Eventuais:	4,00%	Área priv (m²):	32,93	Gape / Mês Unit.:	11,08

Resultado

LI (R$):	15.488.955	LI:	21,80%	Exposição de Caixa (R$):	16.016.743	Margem Bruta Econômica:	40,17%
TIR:	139,40%	LI Aprovação:	20,00%	Ger. Caixa 12 meses (R$):	0	Margem Bruta REF:	43,28%
Exposição de Caixa:	11,21%	Δ LI:	1,80%	Ger. Caixa 24 meses (R$):	(702.911)	Margem Rasa Econômica:	33,90%
Payback Contingente (21 m):	20 m/ (-1 m)	LI Resiliência:	7,81%	Ger. Caixa Marginal (R$):	38.487.125	Margem Rasa REF:	38,02%
Payback Consolidado:	20 meses					Margem de Contribuição Econômica:	28,62%

Informações Financeiras

R$ Mil - Valores Nominais - Compra	Laranjal		sem vaga		vaga moto		vaga carro	
	Nominal	%	Nominal	%	Nominal	%	Nominal	%
Receita	142.860	100,0%	89.896	100,0%	15.447	100,0%	37.517	100,0%
PIS/COFINS	(2.176)	1,5%	(1.232)	1,4%	(275)	1,8%	(669)	1,8%
Custo Total	(84.174)	59,8%	(54.133)	61,1%	(9.071)	59,8%	(20.971)	56,9%
Custo Terreno	(3.835)	2,7%	(2.408)	2,7%	(415)	2,7%	(1.013)	2,7%
Custo Relacionados a Terreno	(760)	0,5%	(488)	0,5%	(82)	0,5%	(191)	0,5%
Custos de Incorporação	(2.312)	1,6%	(1.449)	1,6%	(276)	1,8%	(587)	1,6%
Custo de Construção	(77.268)	54,9%	(49.789)	56,2%	(8.298)	54,7%	(19.181)	52,1%
Lucro Bruto Econômico	56.509	40,2%	34.531	38,9%	6.101	40,2%	15.877	43,1%
Custo para Rateio	-	0,0%	-	0,0%	-	0,0%	-	0,0%
Lucro Bruto Contábil	56.509	40,2%	34.531	38,9%	6.101	40,2%	15.877	43,1%
Despesas de Selling	(12.956)	9,2%	(8.167)	9,2%	(1.388)	9,2%	(3.401)	9,2%
Contingência	(3.286)	2,3%	(2.068)	2,3%	(355)	2,3%	(863)	2,3%
Margem de Contribuição	40.268	28,6%	24.297	27,4%	4.357	28,7%	11.614	31,5%
IR e CSLL	(1.781)	1,2%	(1.008)	1,1%	(225)	1,5%	(547)	1,5%
Margem Líquida	38.487	27,4%	23.288	26,3%	4.132	27,2%	11.067	30,0%
Lucro Bruto REF Unit.	112.086	43,3%	106.335	42,0%	112.096	43,3%	127.013	46,3%
Lucro Raso REF Unit.	90.077	38,0%	84.343	36,5%	90.070	38,0%	104.967	41,6%

R$ Mil - VPL - Compra	Laranjal		sem vaga		vaga moto		vaga carro	
	VP	%	VP	%	VP	%	VP	%
Receitas	71.049	100,0%	44.628	100,0%	7.720	100,0%	18.701	100,0%
PIS/COFINS	(1.066)	1,5%	(603)	1,4%	(136)	1,8%	(328)	1,8%
Custos e Despesas Totais	(54.493)	76,7%	(34.847)	78,1%	(5.901)	76,4%	(13.745)	73,5%
Custo Terreno	(1.918)	2,7%	(1.203)	2,7%	(209)	2,7%	(506)	2,7%
Custo Relacionados a Terreno	(519)	0,7%	(333)	0,7%	(56)	0,7%	(130)	0,7%
Custos de Incorporação	(1.325)	1,9%	(828)	1,9%	(159)	2,1%	(339)	1,8%
Custo de Construção	(41.276)	58,1%	(26.597)	59,6%	(4.433)	57,4%	(10.246)	54,8%
Despesas de Selling	(7.725)	10,9%	(4.854)	10,9%	(842)	10,9%	(2.030)	10,9%
Contingência	(857)	1,2%	(539)	1,2%	(93)	1,2%	(225)	1,2%
IR e CSLL	(873)	1,2%	(493)	1,1%	(111)	1,4%	(269)	1,4%
Lucro Imobiliário	15.489	21,8%	9.178	20,6%	1.683	21,8%	4.628	24,7%

Pareceres

Análise da Mancha e Implantação

Prospecção

Operações

Incorporação

Inteligência de Mercado

Financeiro

Anexos

- **DESCRIÇÃO DOS IMÓVEIS:** Trata-se dos imóveis situados na Cidade de Itaquaquecetuba, Estado de São Paulo, na Rua Laranjal, designados Chácaras 13 e 14, Partes "A", "B", "C", "D", "E", "F", "G", "H" e "I", parte das Chácaras 13 e 14 da quadra A, do Loteamento Chácaras Águas da Pedra, objeto das Matrículas nºs 341.184, 34.185, 34.186, 34.187, 34.188, 34.189, 34.190, 34.191 e 34.192, do 1º Oficial de Registro de Imóveis da Comarca de Itaquaquecetuba/SP, inscritos na Prefeitura Municipal sob os códigos cartográficos nºs 44461-63-95-0391-00-000, 44461-63-95-0379-00-000, 44461-63-95-0349-00-000, 44461-63-95-0344-00-000, 44461-63-95-0339-00-000, 44461-63-95-0334-00-000, 44461-63-95-0329-00-000, 44461-63-95-0324-00-000 e 44461-63-95-0314-00-000, respectivamente.

- **PROPRIETÁRIA: M & F Incorporadora e Construtora Ltda**, inscrita no CNPJ/MF sob o nº 09.343.155/0001-03, com sede em **Guarulhos**/SP. Não possui filiais.

- **CONSIDERAÇÕES PRÉVIAS SOBRE O IMÓVEL:**

(a) Loteamento: não foi objeto de análise preliminar;
(b) Área Construída: não consta área construída averbada nas matrículas nem nos dados cadastrais;
(c) Débitos Imobiliários: conforme certidões imobiliárias emitidas, em 23/07/2025, não constam débitos tributários e não tributários vencidos dos contribuintes;
(d) Multas: não foi objeto de análise preliminar;
(e) Ônus e Gravames: inexistem ônus ou gravames nas nove matrículas abertas;
(f) Ocupação: não foi objeto de análise preliminar;
(g) TAC: não foi objeto de análise preliminar;
(h) CONDEPHAAT, CONPRESP, IPHAN, DESAP: não foi objeto de análise preliminar;
(i) Função Social da Propriedade: não foi objeto de análise preliminar.

ESTUDOS TÉCNICOS E JURÍDICOS: não foi objeto de análise preliminar. A necessidade de retificação de área será analisada no ato da contratação de profissional capacitado para a realização de estudos técnicos.

➢ **CONSIDERAÇÕES SOBRE A EMPRESA PROPRIETÁRIA: M & F INCORPORADORA E CONSTRUTORA LTDA**

- **i)** Processos:
  - 03 (três) apontamentos na **Certidão Cível Estadual**, sendo: 01 (uma) Execução Fiscal referente a IPTU (**imóvel diverso**) distribuída na Comarca de São Paulo; 01 (uma) Execução Fiscal referente a "Multa Obra SDU", distribuída na Comarca de Guarulhos, em 06/01/2023, com o valor atualizado até 09/05/2025 de **R$ 76.098,48**; e, 01 (uma) ação referente a obrigação de fazer cumulada com indenização por danos morais, distribuída em 30/08/2024, com valor de causa de **R$ 100.000,00** (cem mil reais) e pendente de sentença;
  - 02 (dois) apontamentos na **Certidão Trabalhista** da 2ª Região, sendo: 01 (uma) reclamação trabalhista distribuída em 08/02/2020 e com sentença proferida, em 30/04/2025, extinguindo a execução por quitação integral da obrigação pela reclamada; e, 01 (uma) reclamação trabalhista com acordo homologado, em 25/03/2025, no qual a reclamada pagará ao reclamante a importância líquida de R$ 10.000,00 (em cinco parcelas, sendo a última em 11/08/2025).

- **ii)** Débitos municipais:
  - Pendente a CND de Itaquaquecetuba – local dos imóveis (necessária a informação do CCM), mas em pesquisa de débitos em 29/08/2029, nada consta;
  - Apresentada certidão **positiva de débitos** referente a Comarca de Guarulhos, emitida em 24/07/2025, constando débito no valor de **R$ 38.314,70** (Multa DRM) referente ao contribuinte de inscrição mobiliária nº 0167994.

- **CONSIDERAÇÕES SOBRE OS SÓCIOS DA EMPRESA PROPRIETÁRIA**

- **A) AICHE AHMAD MALAS AYOUB – com participação de 95.000 quotas (95%)**

- **i)** Processos: 02 (dois) apontamentos na **Certidão Cível Estadual**, sendo: 01 (um) referente a ação de cobrança, distribuída em 20/05/2016, tendo sido julgada improcedente e mantida a decisão em segunda instância com o trânsito em julgado; e, 01 (um) referente a procedimento comum, distribuído em 07/11/2003, com o valor de causa de R$ 1.588,49 e com acordo homologado, em 10/04/2007, constando como arquivado provisoriamente, desde 16/03/2018.

- **ii)** Débitos Municipais:
  - Pendente a CND de Itaquaquecetuba – local dos imóveis (necessária a informação do CCM), no entanto, em pesquisa de extrato de débitos, em 29/08/2025, nada consta;
  - Apresentada certidão **positiva de débitos** referente a Comarca de Guarulhos, emitida em 24/07/2025 – necessária a apresentação do relatório detalhado de pendências.

- **B) ALI HUSSEIN AYOUB – com participação de 5.000 quotas (5%)**

- **i)** Processos: não constaram apontamentos nas certidões dos distribuidores cíveis, trabalhistas e da Justiça Federal.

- **ii)** Débitos Municipais: Pendente a CND de Itaquaquecetuba – local dos imóveis (necessária a informação do CCM), em pesquisa de extrato de débitos, em 29/08/2025, não consta como contribuinte.

- **CONSIDERAÇÕES SOBRE A EMPRESA ANTECESSORA: SP ARMAZENS GERAIS LTDA**, inscrita no CNPJ/MF sob o nº 60.691.896/0001-24, com sede em **São Paulo**/SP.

- **i)** Processos:
  - Constaram 29 (vinte e nove) apontamentos na certidão dos distribuidores cíveis, sendo: 01 (uma) Desapropriação de imóvel localizado no Arujá/SP; 02 (duas) ações de Usucapião de imóveis localizados em Guarulhos/SP; 01 (uma) Reintegração de Posse de imóvel localizado em Guarulhos/SP; 01 (uma) Monitória julgada improcedente e com o trânsito em julgado; 23 (vinte e três) Execuções Fiscais de IPTU referentes a **imóveis diversos**; e, 01 (um) Cumprimento de Sentença, distribuído em 28/11/2020, pelo qual a Municipalidade de Guarulhos requer o pagamento do montante de **R$ 34.037,65**, referente aos honorários sucumbenciais fixados nos autos de Embargos à Execução opostos pela ora executada e com sentença desfavorável.

- **ii)** Débitos municipais:
  - Pendente a CND de Itaquaquecetuba – local dos imóveis (necessária a informação do CCM), no entanto, em consulta de extrato de débitos, em 29/08/2025, constam 3 (três) autos de infrações, exercício 2001, no valor de **R$ 58.699,63**;
  - Emitido extrato constando restrições referentes a tributos Mobiliários na Comarca de São Paulo (sede), expedido em 24/07/2025 – deve ser apresentado o relatório detalhado de pendência.

- **CONCLUSÃO PRELIMINAR:**

De acordo com os documentos e certidões apresentados até o momento, identificamos, em **sede preliminar**:

(i) em relação ao **IMÓVEIS**:

- com base na documentação recebida, não identificamos pontos de alerta.

(ii) em relação a **EMPRESA VENDEDORA**:

- há 01 (um) acordo trabalhista em andamento, tendo sido homologado em 25/03/2025, no valor líquido de **R$ 10.000,00,** em cinco parcelas, sendo a última em 11/08/2025;
- Constou 01 (uma) Execução Fiscal referente a "Multa Obra SDU", distribuída na Comarca de Guarulhos, em 06/01/2023, com o valor atualizado até 09/05/2025 de **R$ 76.098,48**;
- há 01 (uma) ação referente a obrigação de fazer cumulada com indenização por danos morais, distribuída em 30/08/2024, com valor de causa de **R$ 100.000,00** (cem mil reais) e pendente de sentença.

(iii) em relação ao **SÓCIO *Ali Hussein Ayoub***, pelo que nos foi apresentado, não há apontamentos relevantes que possam colocar em risco a segurança jurídica do negócio pretendido.

(iv) em relação a **SÓCIA *Aiche Ahmad Malas Ayoub***, pelo que nos foi apresentado, não há apontamentos relevantes que possam colocar em risco a segurança jurídica do negócio pretendido.

(v) em relação a **ANTECESSORA**:

- constou 01 (um) Cumprimento de Sentença, distribuído em 28/11/2020, pelo qual a Municipalidade de Guarulhos requer o pagamento do montante de **R$ 34.037,65**, referente aos honorários sucumbenciais fixados nos autos de Embargos à Execução opostos pela ora executada e com sentença desfavorável e sem movimentações conclusivas no Portal do TJSP;
- está pendente de apresentação a CND de Itaquaquecetuba – **local dos imóveis** (necessária a informação do CCM).

LEGALIZAÇÃO

➢ ÁREA DE IMPLANTAÇÃO

- O terreno atualmente é composto pelas Matrículas nºs 341.184, 34.185, 34.186, 34.187, 34.188, 34.189, 34.190, 34.191 e 34.192, do 1º Oficial de Registro de Imóveis de Itaquaquecetuba/SP. Foi acordado que **ficará a cargo do proprietário o englobamento e posterior desmembramento** destas matrículas, perfazendo a área líquida de 8.225 m², objeto do nosso estudo e desenvolvimento;
- Nosso cronograma foi condicionado à **conclusão do desmembramento em até 6 meses**, ou seja, à emissão da matrícula da área dentro desse período para garantir a continuidade do processo de licenciamento conforme planejado.

➢ DIRETRIZ URBANÍSTICA

- A revisão da Lei de Uso, Ocupação e Parcelamento do Solo foi aprovada em 02/12/25, e o projeto foi desenvolvido já considerando a nova legislação e todos os seus parâmetros urbanísticos vigentes.

➢ GRAPROHAB

- Considerado GRAPROHAB, uma vez que a via de acesso não é pavimentada e não dispõe de sistema de drenagem, não atendendo às condições mínimas de infraestrutura exigidas para dispensa.
- Possível exigência de prolongamento da rede de água, implantação de ETE e realização de intervenções em APP, estas últimas necessárias para a solução de drenagem.

➢ URBANIZAÇÃO

- Necessária interlocução com a Secretaria de Planejamento/Trânsito para avaliação de eventual melhoramento viário, incluindo o alargamento da via existente. O estudo de massa atual prevê a reserva da área necessária para essa intervenção.
- Haverá necessidade de pavimentação da via principal.

➢ CONTRAPARTIDA

- Haverá cobrança de medida mitigadora, e o Secretário de Planejamento orientou considerar R$ 255.000,00 com base na área construída de 18.704,24 m².

LEGALIZAÇÃO

➢ HIDROGRAFIA

- Há uma APP resultante de um córrego vizinho aos fundos do terreno, lindeira ao mesmo;
- Necessária a solicitação do laudo de cota de cheia; contudo, em razão da topografia natural do terreno, não identificamos este item como ponto relevante de atenção.

➢ COMAER

- Necessária a realização de pré-análise para confirmação, contudo não identificamos risco relevante associado a este item.

➢ AVALIAÇÕES AMBIENTAIS

Arbóreo

- Há uma APP nos fundos do terreno, lindeira ao mesmo;
- Há a presença de poucos exemplares de árvores isoladas, para fins de orçamento, consideramos 15 exemplares;
- Até 2023, o terreno apresentava árvores de grande porte de forma isolada, posteriormente suprimidas. O proprietário apresentou o respectivo TAC, devidamente regularizado, para comprovação da conformidade ambiental.

Contaminação de Solo

- O imóvel é possivelmente classificado como não contaminado, considerando a ocupação atual e os usos pretéritos do solo;
- Não há histórico de imóveis contaminados próximos do local de estudo;
- Consideramos no orçamento apenas o Estudo Preliminar.

LEGALIZAÇÃO

➢ ÓRGÃOS DE PATRIMÔNIO HISTÓRICO

- Municipal: Não apresentado, mas entendemos que não há risco.
- Estadual – Condephaat: Não apresentado, mas entendemos que não há risco.
- Federal – IPHAN: Não apresentado, mas entendemos que não há risco.

➢ ABASTECIMENTO SANITÁRIO

- A Diretriz da SABESP foi solicitada pela área de Prospecção, com previsão de recebimento em janeiro/26, em razão do prazo atualmente dilatado do órgão;
- Por observação do entorno, entendemos que será solicitada extensão de reforço de água e de esgotamento;
- Para minimizar o impacto, consideramos ETE no terreno, mas necessária solicitação de intervenção em APP e no terreno vizinho.

➢ DRENAGEM

- O lançamento da drenagem será direcionado ao córrego situado nos fundos do terreno vizinho. Para viabilizar a solução, será necessária a solicitação de intervenção em APP e a instituição de servidão de passagem no imóvel vizinho a jusante, relativo à área remanescente do desdobro da área original objeto de aquisição;
- Será solicitado estudo hidrológico prevendo cota de inundação devido á proximidade do córrego, mas entendemos que não será um item crítico.

➢ MOVIMENTAÇÃO DE TERRA

- Entender a necessidade de aprovação de projeto de movimentação de terra junto ao município.

➢ OUTROS ITENS NECESSÁRIOS/ESPECÍFICOS

- Considerar GLP em projeto.

LEGALIZAÇÃO

Laranjal

	set/25	out/25	nov/25	dez/25	jan/26	fev/26	mar/26	abr/26	mai/26	jun/26	jul/26	ago/26	set/26	out/26	nov/26	dez/26	jan/27	fev/27	mar/27	abr/27	mai/27	jun/27	jul/27	ago/27	set/27	out/27	nov/27	dez/27	jan/28	fev/28
	1	2	3	4	5	6	7	8	9	10	11	12	13	14	15	16	17	18	19	20	21	22	23	24	25	26	27	28	29	30
PROSPEC - Comitê Essencial																														
PROSPEC LEG DPP - Baixa LB / Reunião de Passagem																														
PP - Definição poligonal																														
PP - Englobamento e Desmembramento																														
PP - Emissão de matrícula																														
LEG - Complemento estudos técnicos																														
Planialtimétrico																														
Sondagem																														
SABESP																														
Ambiental (Preliminar)																														
Arbóreo																														
Hidrológico																														
Certidões de tombamento (MUN/EST/FED)																														
LEG - Certidão de Uso do Solo																														
LEG - Emissão lei com liberação do HIS para R4																														
LEG - Diretriz Urbanística 1																														
LEG - Manifesto Ambiental																														
PROJ - AP																														
PROJ - PL AP																														
NEG - Comitê Tenda Ampliado																														
LINHA - KIT EP																														
LINHA - Elaboração PL EP																														
LEG - NBR																														
LEG - Aprovação Drenagem (Verificar sobre projeto complementar)																														
LEG - Aprovação movimentação de terra (Verificar sobre projeto complementar)																														
LEG - Diretriz Urbanística 2																														
LEG - Aprovação supressão vegetação																														
NEG - Carta de enquadramento CEF																														
LEG - Alvará de aprovação e execução																														
LEG - Certidão de Conformidade																														
LEG - Cadastro de Habitação - 20% das uh vendidas para lista da prefeitura																														
LEG - Aprovação GRAPROHAB																														
JUR - Escritura e RI																														
CRE - Contratação CEF																														
NEG - Lançamento																														

Obrigado