Tenda

sua próxima conquista

Comitê de Investimentos – Essencial

Regional: SP – Zona Central Sul

Projeto: Estrada das Lágrimas

Data Comitê: 16.03.2026

Questionamentos comitê digital 09.03.2026

Nome	Estrada das Lágrimas - Essencial de Investimento	Observação - Estrada das Lágrimas
Andre Luis Menegazzo Padilha	Aprovado	ok
Alejandro Octavio Abiusi	Aprovado	ok
Fabricio Quesiti Arrivabene	Aprovado	ok
Alexandre Regis de Oliveira	Aprovado	ok
Amanda da Silva Bezerra	Aprovado	ok
Renan Barbosa Sanches	Aprovado	ok
Rodrigo Osmo	Discutir em comitê	(1) Nós chegamos a discutir qual % das unidades que computaríamos para um projeto em comite Essencial que não atinge os 22% de LI? Minha proposta seria que fosse 50% dos 70% (i.e., 35%) das unidades que normalmente computamos no “essencial”; (2) Entendo que podemos desistir futuramente da compra, com o proprietário devolvendo o sinal, certo?; (3) Qual seria a penalidade para o proprietário caso o lançamento atrase por algum problema dele (uma vez que já teremos pago um sinal relevante)?
Luiz Mauricio de Garcia Paula	Aprovado	ok

Rodrigo Osmo | Dúvida (1): Nós chegamos a discutir qual % das unidades que computaríamos para um projeto em comite Essencial que não atinge os 22% de LI? Minha proposta seria que fosse 50% dos 70% (i.e., 35%) das unidades que normalmente computamos no "essencial";

Resp.: EE (Estudos Econômicos) - *Em Abril/25, quando foram estabelecidas as diretrizes do comitê Essencial, houve discussão sobre o tema. Visando a simplificação dos controles, ficou definido que adotaríamos o mesmo waiver de até 3p.p. com contabilização de 50% das unidades totais.*

O racional é de que a regional já tem um prazo limite de 12 meses para voltar em comitê ampliado, no qual tem a obrigatoriedade de atingir a régua para validar o restante das UHs. Lembrando que o insucesso do comitê ampliado acarreta no descarte do projeto e perda das UHs ganhas em meta.

Adicionalmente, os projetos Aurora (Etelvina) e Max Berger já foram baixados nessa condição em 2025.

Rodrigo Osmo | Dúvida (2): Entendo que podemos desistir futuramente da compra, com o proprietário devolvendo o sinal, certo?

Resp. Prospecção ZS.: Sim. O contrato prevê que, caso não seja possível superar a segunda tranche de condições resolutivas, a Compradora poderá rescindir o negócio. Nessa hipótese, o valor pago a título de sinal deverá ser devolvido pelo proprietário em até 30 dias, contados da notificação formal da Tenda para formalização do distrato.

Segue abaixo o trecho da cláusula contratual correspondente:

6.2. No caso da não superação de quaisquer das Condições Resolutivas retro apontadas na Cláusula 6.1, a **COMPRADORA** poderá, a seu exclusivo critério, optar por: **(a)** dar por superada a respectiva condição; **(b)** manter vigente o presente instrumento, suspendendo, contudo, os prazos contratuais, pelo prazo que for necessário para que se regularize a situação, caso em que o presente instrumento permanecerá válido e eficaz, suspendendo-se o pagamento do **Preço** e a lavratura da competente escritura definitiva de venda e compra do **Imóvel**, sendo certo que não haverá a incidência de quaisquer penalidades ou multas; ou **(c)** dar por rescindido o presente negócio, sem qualquer penalidade de parte a parte, exceto a devolução, em até 30 (trinta dias), contados de comunicação que a **COMPRADORA** fará nesse sentido, da parcela prevista na cláusula 2.1 "i", paga a título de sinal, sem prejuízo do disposto nos itens 6.5 e 6.5.1, infra.

2.1. Pelo presente instrumento e na melhor forma de direito, a **VENDEDORA** compromete-se a alienar à **COMPRADORA** o **Imóvel**, obrigando-se esta a adquirir, de forma inteiramente livre e desembaraçada, desocupado de pessoas e coisas, pelo preço total de **R$ 15.700.000,00 (quinze milhões e setecentos mil reais)** ("**Preço**"), a ser pago da seguinte forma:

(i) R$ 3.140.000,00 (três milhões e cento e quarenta mil reais), correspondentes a 20% (vinte por cento) do **Preço**, a ser pago em 10 (dez) parcelas mensais, fixas e consecutivas, no valor de R$ 314.000,00 (trezentos e quatorze mil reais) cada uma delas ("**Sinal**"); sendo que para fazer *jus* ao recebimento deste valor, a **VENDEDORA** se obriga a constituir, em favor da **COMPRADORA**, a alienação fiduciária em garantia, a ser formalizada por escritura pública, observada a Cláusula 2.1.2. abaixo e;

Rodrigo Osmo | Dúvida (3): Qual seria a penalidade para o proprietário caso o lançamento atrase por algum problema dele (uma vez que já teremos pago um sinal relevante)?

Resp. Prospecção ZS.:
O contrato firmado prevê a aplicação de multa rescisória equivalente a 10% do valor do negócio caso a vendedora descumpra quaisquer obrigações contratuais por prazo superior a 15 dias após notificação. Além disso, o valor pago a título de sinal está garantido por Alienação Fiduciária do próprio imóvel em favor da Tenda, trazendo maior segurança à operação.

Segue abaixo o trecho da cláusula contratual correspondente:

B – DAS CAUSAS DE RESCISÃO

6.5. A **COMPRADORA** poderá considerar rescindido este Contrato se a **VENDEDORA** atrasar, injustificadamente, e desde que previamente notificado com 15 (quinze) dias de antecedência, a outorga da Escritura de Venda e Compra ou o cumprimento de quaisquer das obrigações assumidas por força do presente instrumento, por mais de 15 (quinze) dias contados da data aprazada, o que acarretará a **VENDEDORA** a aplicação de multa rescisória no valor correspondente a 10% (dez por cento) sobre o valor do presente negócio em favor da **COMPRADORA**.

One Page – Estrada das Lágrimas

[1]

Cidade	São Paulo	**Mancha de demanda**	SP - SZC - São Paulo Centro
Regional	SP	**Cluster MPR**	3 - Verde
Cenário de Aprovação	Aprovação	**Tipo de Aprovação**	Consolidado
Fase Anterior	N/A		
Tipo de Comitê	Essencial	**Versão da VF**	Versão 1.0: Fev

[2]

Unidades (Fases)	565 (1)	**CA Máx | Proj**	5,4 | 5,1
Unidades com Vaga (%)	0 (0%)	**Escritura | Lançamento**	jan/28 | mar/28
Unidades com Varandas (%)	282 (50%)	**Tipologia**	F2E - Concreto

[3]

Valor Líquido do Terreno (% VGV)	15.700 (9,9%)	**Un. Perm. Fís (% Ter)**	0 (0,0%)
Cash (Correção)	15.700 (IPCA)	**%VGV Perm Fin Líquida (% Ter)**	0,0% (0,0%)
Valor R$/m²	4.569	**VAR (%VGV)**	000 (0,0%)

Custo Construção (%VGV)	59.970 (37,7%)	**Indireto Unit.**	21.619
Prazo da Obra (meses)	20	**Torre Unit.**	60.258
Custo Total Unit. | Corrigido (LPU):	106.141 | 106.908 (99)	**Infra Unit.**	14.317
Início de Obra	set-28	**Fundação Unit.**	8.536

Preço Nominal Unit.	281.421	**VSO**	31
Preço Raso Unit.	248.278	**Referência**	Vision
Avaliação Unit.	293.504	**Renda (% em RET 1%)**	4.837 (0,0%)

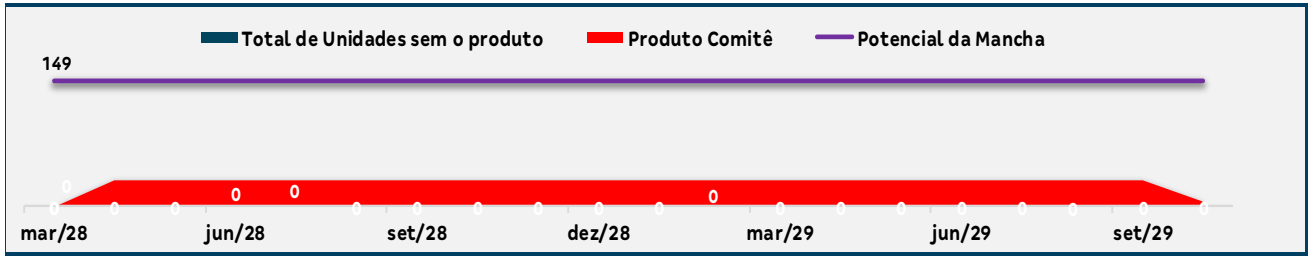

[4]

LI (Régua):	**20,4% (22,0%)**	**Margem Bruta Econômica:**	43,5%
LI Resiliência:	7,8% (N/A)	**Margem Rasa Econômica:**	34,7%
Margem Bruta REF:	46,3%	**Margem Contribuição Econômica:**	31,0%
Margem Rasa REF:	**39,1%**	**Exposição (% VGV):**	26.756 (15,3%)
TIR:	67,2%	**VGV Total:**	**159.003**
Payback Contingente (21 m) :	**21 m/ (0 m)**	**Ger. Caixa 12 meses (R$):**	(2.512)
Payback Consolidado:	21	**Ger. Caixa 24 meses (R$):**	(6.109)

Destaques

[1] Localização: Terreno "pequeno" com 3.540m2 situado em localização diferenciada na ZS, na Estrada das Lágrimas, nº 2.986 – São João Clímaco, a aproximadamente 1 km da Rodovia Anchieta, a 2km do Parque Shopping São Caetano, e 4 km do Terminal de Ônibus e Metrô Sacomã.

[2] Projeto: O projeto é composto por condomínio único, com 565 unidades, com 50% das unidades com varanda e área de lazer com piscina. O terreno está inserido em zoneamento ZC (Zona de Centralidade) com gabarito limitado 48M (T+17). O projeto prevê 3 torres, sendo 2 geminadas T+17 (em "L") e terceira T+14 com gabarito limitado nesta 2ª torre em função dos afastamentos. O Coeficiente de Aproveitamento (CA) máximo permitido é 5,4, sendo que o projeto atinge CA 5,06 com eficiência de 94%.

[3] Condição Comercial:
Valor total: R$ 15,7 MM, equivalente a R$ 4,4K/m2, R$ 876/CA e fração 9,9%;
Forma de Pagamento 100% em dinheiro, sendo**: Sinal:** equivalente a 2% do VGV e 20% do negócio (R$ 3,14 MM), com Alienação Fiduciária em garantia, a ser pago em 10 parcelas fixas, sem correção, com início após a superação da Primeira Tranche de Resolutivas; **Saldo:** equivalente a 80% do negócio (R$ 12,56 MM), em 24 parcelas mensais a partir da escritura, corrigidas pelo IPCA/IBGE com data base na escritura; **Intermediação**: R$ 785 mil fixo e irreajustável, correspondente a 5%, em 5X à partir da escritura.

[4] Comitê: O enquadramento será no formato Essencial. Como estamos abaixo da régua, será considerado 50% do total de unidades para efeito de apuração. Há expectativa de atingimento da régua de 22% no comitê ampliado com a evolução dos estudos, potencial de ampliação do % de varandas em função da renda da região e limitação de apenas 122 unidades (21%) em HIS1 (parte do benefício de CA), avanço no entendimento do potencial de preço para a região e concorrência, ou mesmo renegociação da fração.

EE: Foi considerado o custo de Equipados e Ambientados, tabela em anexos, no slide 32

Seguindo o Decreto nº 64.895, de 5 de janeiro de 2026, o projeto contempla preços exclusivamente dentro dos limites de HIS 1 R$ 276.102,20 com renda de até R$ 4.863,00 e HIS-2: R$ 383.636,74 e renda de até R$ 9.726,00

Pareceres

Análise da Mancha e Implantação

Prospecção

Operações

Incorporação

Inteligência de Mercado

Financeiro

Anexos

Pareceres

Área	Riscos Associados	Parecer	Criticidade
Jurídico Aquisição	Recomendamos o prosseguimento da assinatura do Instrumento de aquisição do Imóvel, sendo certo que não foram constatados registros capazes de indicar risco relevante à aquisição do imóvel. Importante destacar que a análise de todas as certidões da Proprietária, do sócio da Proprietária, de eventuais empresas das quais participe e dos Antecessores, será efetuada no âmbito da Due Diligence imobiliária, sendo importante obter esclarecimentos sobretudo quanto ao apontamento indicado acima, bem como emitir as certidões fiscais ou obter retornos satisfatórios sobre tais pendências.	Ok com ressalvas	
Legalização	Terreno com demolição.	Ok	
Produto	Necessário confirmação da poligonal. Qualquer alteração poderá impactar na implantação	Ok	
Inteligência de mercado	IM avalia o Preço Vision como factível.	Ok	
Comercial/Ciclo	O Ciclo validou o preço e o VSO como viáveis.	Ok	
Estudos Econômicos	Ok considerando a baixa de 50% das Uhs	Ok	

Pareceres

Análise da Mancha e Implantação

Prospecção

Operações

Incorporação

Inteligência de Mercado

Financeiro

Anexos

Prospecção | Localização – Estrada das Lágrimas, 2986 – São João Clímaco – São Paulo/SP

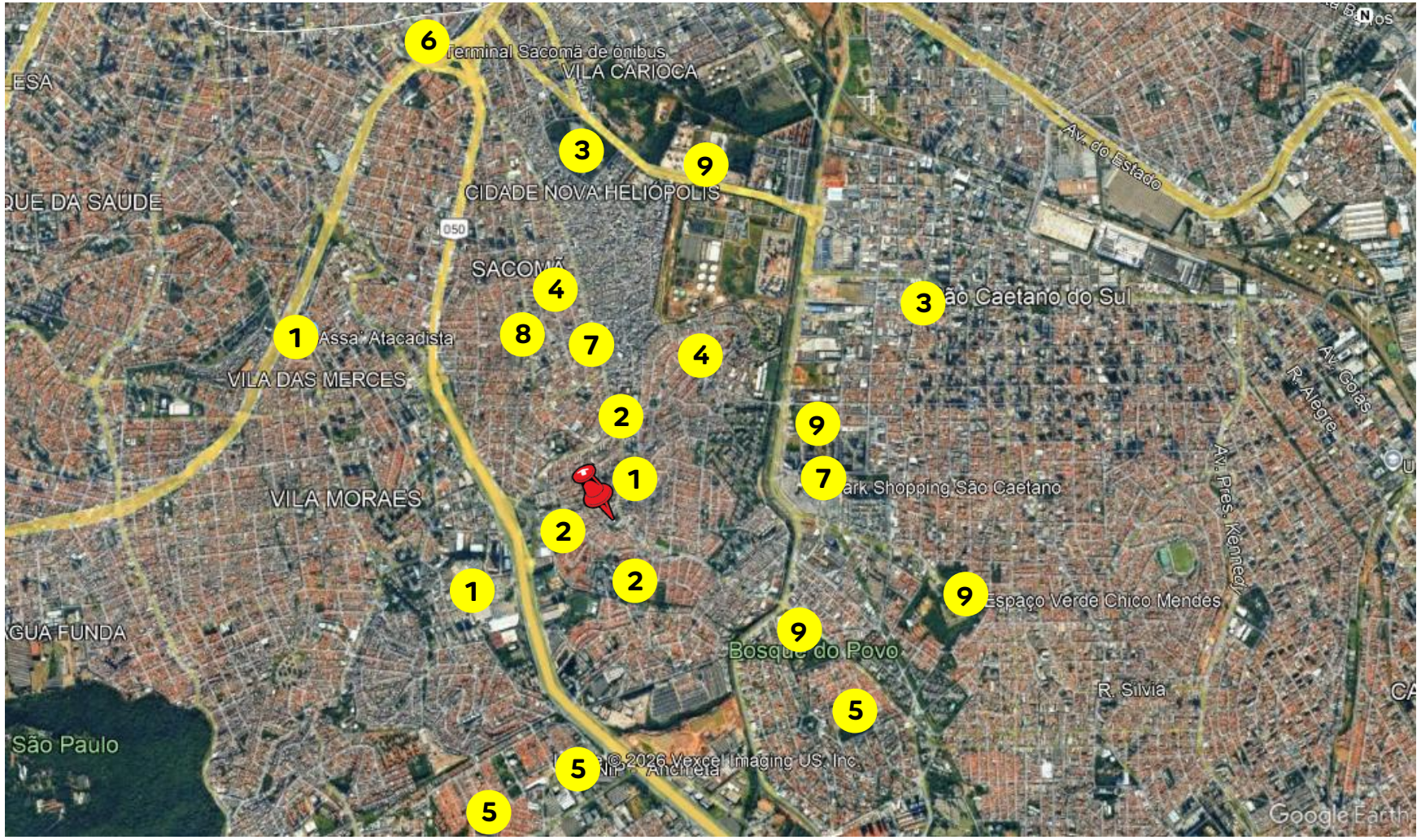

1 Yutaka Supermercados (4 min a pé)
Carrefour Hipermercado

2 CEU Heliópolis (9 min a pé)
EMEI Santo Dias da Silva (10 min a pé)
E.E. Melvin Jones (7 min a pé)

3 Complexo Hospitalar Heliópolis (13 min)
Hospital Central de São Caetano do Sul

4 UBS Vila Arapuá
UBS Sacomã

5 UNIP Anchieta
FMU Sacomã
Fatec São Caetano do Sul

6 Terminal de Ônibus e Estação Sacomã (19 min)

7 Shopping Heliópolis (7 min)
Park Shopping São Caetano do Sul

8 Correios

9 Parque Tom Jobim
Centro de Lazer Chico Mendes
Parque da Cidadania Heliópolis
Bosque do Povo

Prospecção | Acesso – Estrada das Lágrimas, 2986 – São João Clímaco

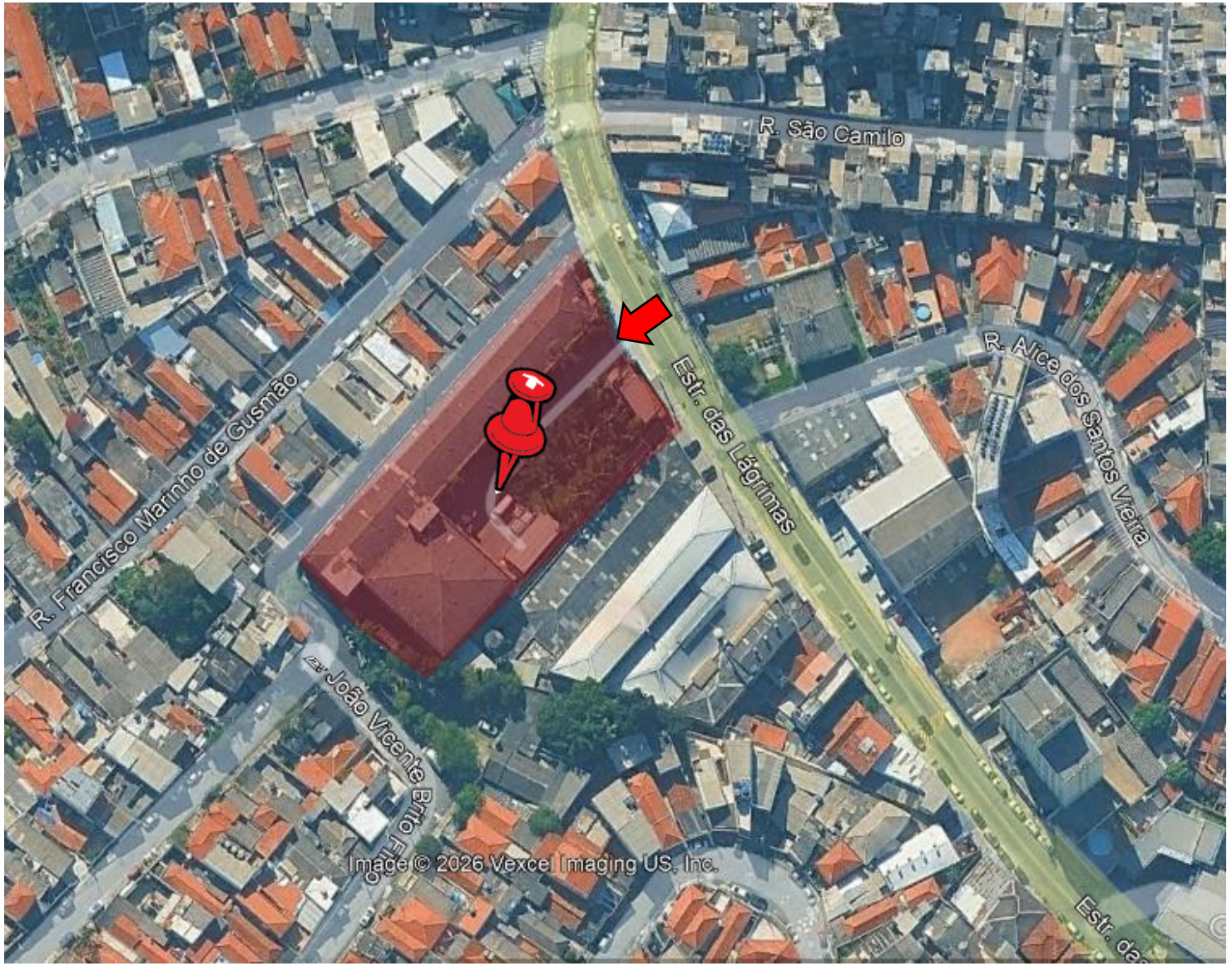

FONTE: GOOGLE EARTH PRO

Mancha de Demanda

MANCHAS DE DEMANDA

- SZC – São Paulo Centro

1. Estrada das Lágrimas

Cluster MPR – (Comitê)

Cluster 3 - Verde

Região

Capital

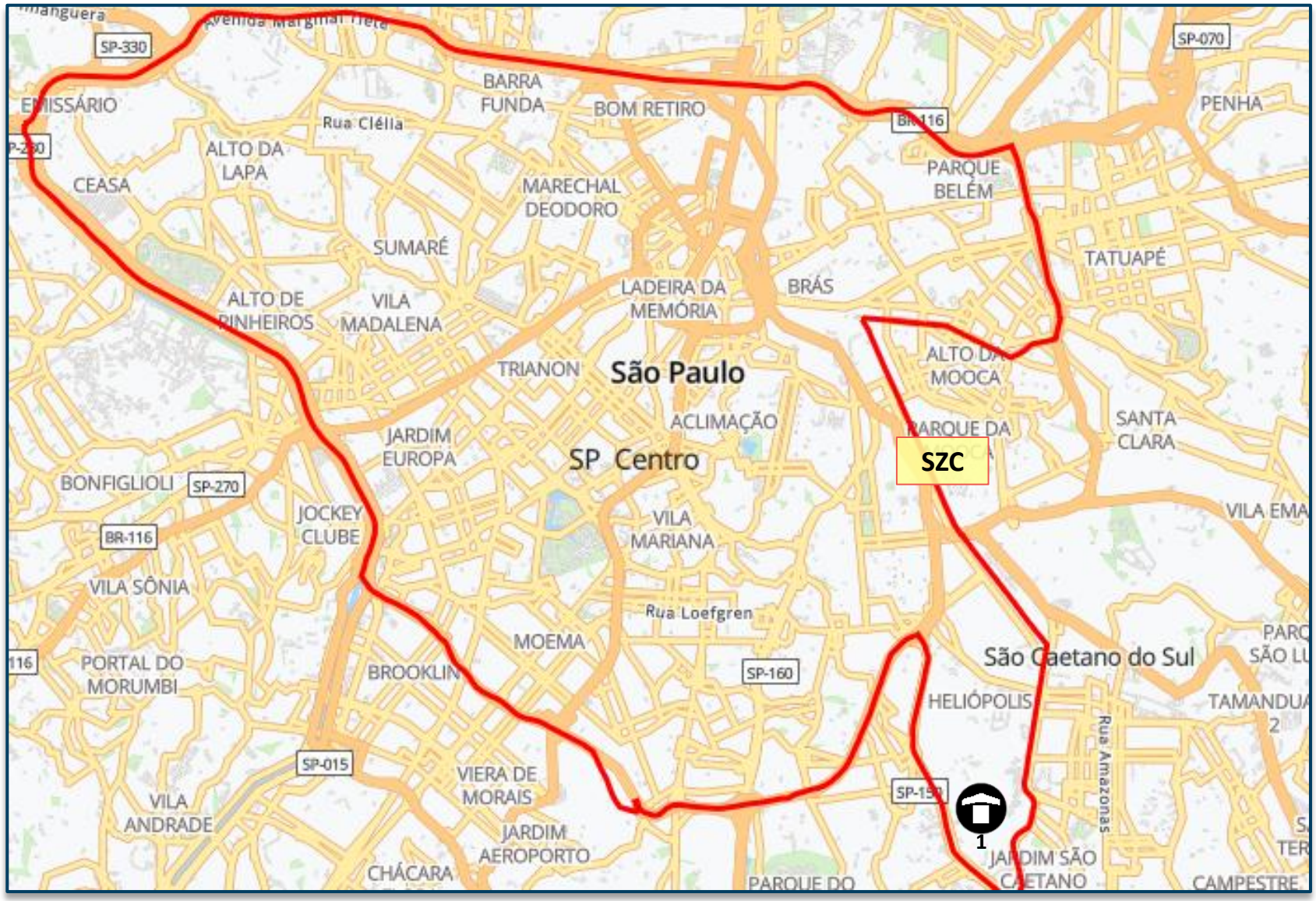

Lançados *LandBank* *Comitê*

PRODUTO

Estrada das Lágrimas
Investimento

Informações Gerais – Condomínio 01			
Terreno	Área terreno (Matrícula)	NA	
	Menor poligonal	3.541,17 m²	
	Reserva de calçada / Melhoramento Viário	104,68 m²	
	Área liquida	3.436,49 m²	
	Zoneamento	ZC	
	CA máximo	5,40	ZONA: 3,00
			INCENTIVO HIS1: 1,50
			COTA: 0,90 *
	CA projetado	5,06	
	CA liquido	5,21	
	Gabarito máximo	48	
Geral	Total UH	565	
	Total de vagas	0	
Tipologia			
	Gabarito	T+17 | T+14	
	Lâminas	1x 12PP-LN-L | 1x 10PP-LN-C | 1x 12PP-LN-C	
	Área privativa	31,84 m²	
Condomínio	Unidade PCD	17	
	Unidade lazer | técnica	08 | 03 UH	
	Torre	03	
	Fase	Única	
Lazer	Lazer coberto	2x Churrasqueira	
	Lazer descoberto projetado	1.162,16 m²	

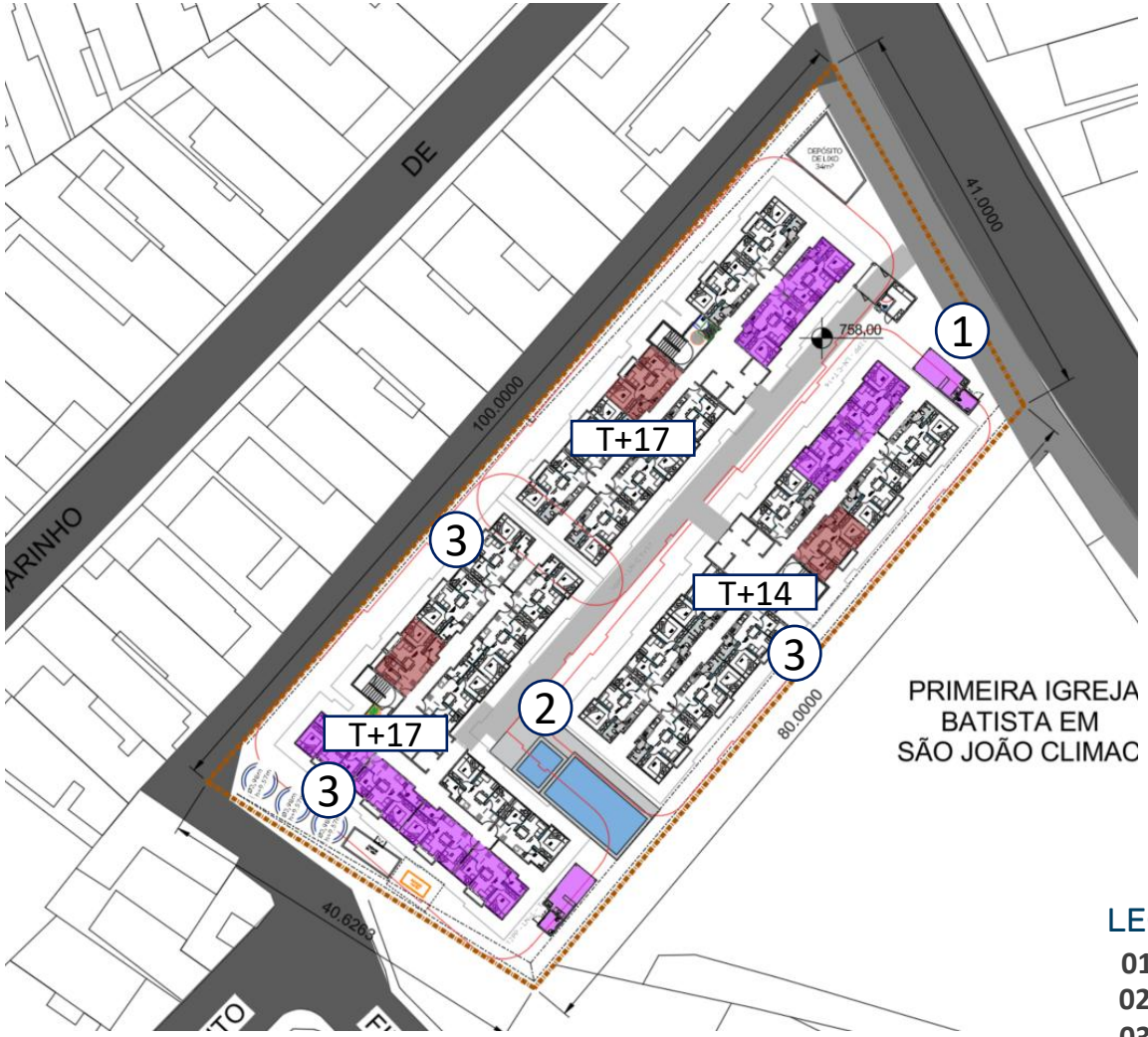

LEGENDA:

01 Reserva de calçada
02 Lazer
03 Face com varanda

ESTUDO DE MASSA

* Nota: Os benefícios urbanísticos utilizados no projeto foram detalhados pelo time de Legalização.

PRODUTO

Estrada das Lágrimas
Investimento

	Descrição	Criticidade	Parecer
Usabilidade	**Acesso Empreendimento**	🟢	
	Percurso do pedestre até torre	🟢	
Diferencial produto	**Prime**	Não	
	Supercondomínio	Não	
	Atributos Infra	Sim	Piscina – Poderá sofrer alterações a depender da poligonal.
	Atributos Torre	Sim	50% varanda
	Edifício Garagem	Não	

	Considerações	Criticidade	Descrição
Material analisado	KMZ	🟢	
	Matrícula	🟢	A matrícula do imóvel indica área (3.760m²) de terreno inferior à constante no IPTU (3.980m²). Para fins de análise preliminar, consideramos a poligonal desenhada com base na descrição da matrícula (3.541,17m²).
	Planialtimétrico	🟡	Não recebido. Utilizado como base o Mapa Digital da Cidade 2004.

Pareceres

Análise da Mancha e Implantação

Prospecção

Operações

Incorporação

Inteligência de Mercado

Financeiro

Anexos

Prospecção | Condições do Negócio

- **VALOR DO NEGÓCIO:**
- R$ 15.700.000,00 –> R$4,4 k/m2 e aproximadamente R$876/CA atingido.

- **FORMA DE PAGAMENTO:** 100% Dinheiro.
  - **Sinal** equivalente a 20% do negócio (R$ 3,14 MM), a ser pago em 10 parcelas fixas, sem correção, com início após a superação da Primeira Tranche de Resolutivas, mediante AF – sinal equivalente e 2% do VGV.
  - **Saldo:** equivalente a 80% do negócio (R$ 12,56 MM), a ser quitado em até 24 parcelas consecutivas, corrigidas pelo IPCA/IBGE, a partir da lavratura da escritura, com início do fluxo nessa mesma data.

- **CORREÇÃO**: Apenas o saldo passará por correção pelo IPCA/IBGE com data base escritura

- **GARANTIAS:** Sinal (AF – Alienação Fiduciária gravada na matrícula do imóvel a favor da Tenda) e o Saldo (Seguro Garantia a favor do proprietário para fluxo pós escritura).

- **ESCRITURA E POSSE:** Concomitante à superação integral das resolutivas do contrato.

- **CORRETAGEM:** R$ 785.000,00, que representa 5%, pagos em 5 parcelas, fixas, iguais e consecutivas com inicio após a lavratura da escritura e sem correções.

- **PRAZOS:**

Tranches de Resolutivas:

- A) I: Em até 4 meses para análises técnicas, jurídicas e financeiras – *Previsão de conclusão: jul/2026.*
- B) II: Em até 18 meses, a critério da COMPRADORA, podendo ser prorrogado em até 6 (seis) meses, caso seja necessário aprovar o projeto do Empreendimento junto ao GRAPROHAB e/ou na hipótese de comprovado atraso na aprovação do projeto por parte dos órgãos competentes – *Previsão de conclusão: jan/2028.*

Prospecção | Observações adicionais

ANTECIPAÇÃO DE DESPESAS:

- Não foram identificadas, até o momento, pendências financeiras ou débitos de IPTU que gerem antecipações de despesas.
- As eventuais despesas com remediação ambiental serão descontadas do valor devido ao proprietário, limitadas ao montante de R$ 750.000,00.
- As eventuais despesas com regularizações da área serão melhores apuradas e descontadas do saldo do preço.

CONDIÇÕES RESOLUTIVAS / DISTRATO:

- As cláusulas de rescisão por inviabilidade técnica, jurídica e financeira não foram alteradas e atendem às nossas necessidades e padrões.
- Devolução do Sinal: Incluímos uma cláusula contratual estabelecendo que, caso não seja possível superar a segunda tranche de condições resolutivas, o valor pago a título de sinal deverá ser devolvido no prazo de até 30 dias contados do envio da notificação pela Tenda, comunicando a necessidade de devolução dos valores e formalização do distrato.

INFORMAÇÕES ADICIONAIS:

- O imóvel está ocupado pelo proprietário e a intenção da venda é a mudança para outro local maior em função da demanda de produção. No local funciona uma gráfica de embalagens que atende empresas como Cacau Show, Stella Artois e DUX Suplementos, entre outras. Os equipamentos existentes são novos, de origem alemã e de última geração. Os pisos do imóvel estão devidamente vedados com tintas apropriadas.

Pareceres

Análise da Mancha e Implantação

Prospecção

Operações

Incorporação

Inteligência de Mercado

Financeiro

Anexos

Custo de Construção

PARÂMETROS		INCC base:	1.228,16	Versão:	jan-26 R01
Empreendimento:	Est das Lágrimas			Prazo pré forma:	5,4
Produto / Selo:	F2E Modular	Contenção:	Nível 2	Prazo forma:	5,9
Pavimentos Médio:	17	Terraplenagem:	Nível 1	Prazo pós Forma:	8,5
Torres:	3	Varanda %:	50%	Prazo total:	20,0
PPs médio:	11,3	Piscina:	Sim	EEE:	Não
Unidades Construídas:	576	ETE:	Não	Geminação entre torres:	Sim

Infra Externa

Viário (m):	0	Extensão Esgoto (m):	50
Drenagem (m):	0	Extensão Água (m):	50

Obras ref. contenção	Obras ref. Terraplenagem
Portal Do Parque	Forte São Lourenço
Viva City Jaraguá F1	Viva City Jaraguá F1
Life Jaguare	
Palermo	

CUSTO TOTAL I	105.445
INDIRETO	21.619
TORRE	60.258
INFRA	14.317
FUNDAÇÃO	8.536
ETE	0
EEE	0
CONTENÇÃO	173
TERRAPLENAGEM	543

Custo de Construção

Est das Lágrimas

ESTIMATIVA

DADOS DA OBRA		BASES		PRAZOS DE OBRA	
Regional:	SP	Data:	fevereiro-26	Pré Forma:	5,4 meses
Endereço:		Revisão:	R00	Estrutura:	5,9 meses
Total de UH:	**576**	LPU:	LPU 99	Pós Forma:	8,5 meses
Total Torres:	3	LVS:	dezembro-25	**TOTAL:**	**20,0 meses**
Produtos:	F2E Modular	INCC:	1.228,161		
Tipologia:	12 e 10PP			Jogos de Formas:	2
				Takt:	2+2

CUSTOS DE CONSTRUÇÃO

	CUSTO	R$ / UND
CUSTO TOTAL I	**R$ 60.209.032**	**R$ 105.445**
INDIRETO	R$ 12.344.289	R$ 21.619
TORRE	R$ 34.407.172	R$ 60.258
INFRA	R$ 8.174.831	R$ 14.317
FUNDAÇÃO	R$ 4.873.912	R$ 8.536
ETE	R$ 0	R$ 0
EEE	R$ 0	R$ 0
CONTENÇÃO	R$ 99.030	R$ 173
TERRAPLENAGEM	R$ 309.799	R$ 543
CUSTO TOTAL II	**R$ 397.354**	**R$ 696**
VIÁRIO	R$ 0	R$ 0
DRENAGEM	R$ 0	R$ 0
EXTENSÃO ELÉTRICA	R$ 104.224	R$ 183
EXTENSÃO HIDRÁULICA	R$ 293.130	R$ 513
CUSTO TOTAL I + II	**R$ 60.606.386**	**R$ 106.141**
CUSTO TOTAL III	**R$ 576.300**	**R$ 1.009**
GEMINAÇÃO ENTRE TORRES	R$ 576.300	R$ 1.009
CUSTO TOTAL I A III	**R$ 61.182.686**	**R$ 107.150**
CUSTO TOTAL I A IV	**R$ 61.182.686**	**R$ 107.150**

OBSERVAÇÕES GERAIS

Parâmetro terraplenagem: Nível 1
Parâmetro Contenção: Nível 2
Geminação entre torres: Sim

RATEIO FASEAMENTO

% de Varanda: 50%
Possui Piscina: Sim
ETE: Não
EEE: Não

Pareceres

Análise da Mancha e Implantação

Prospecção

Operações

Incorporação

Inteligência de Mercado

Financeiro

Anexos

LEGALIZAÇÃO

Tenda

REGIONAL SP

PARAMÉTRICO DE CUSTOS LEGALIZAÇÃO

DADOS		QUANDO APLICAR
Quantidade de unidades	565	
O Empreendimento terá R2V?	SIM	
Qual a área do Terreno?	3.760	
Quanto % do terreno Possui árvore?	10%	Se possivel contas arvores, considerar 16m² X quantidade de arvores / area do terreno. Caso não seja possivel, estimar por poligonal/ area do terreno
# Arbórea estimada no terreno	*24 árvores*	
# corte	*22 árvores*	
# total compensação	*96 árvores*	
# compensação interna	*14 árvores*	
# compensação à deliberar	*81 árvores*	
Classificação Deliberação	*FEMA*	
Possível Área Contaminada?	SIM	Terrenos com histórico de uso industrial anterior; Os vizinhos do entorno podem possuem uso geradores de contaminantes (posto de gasolina, fabricas, gasodutos, etc...);
Esta Cadastrado como Área Possivelmente Contaminada nos Orgão Publicos?	NÃO	Quando no GEOSAMPA estiver classificado como área possivelmente contaminada
Parcelamento do Solo?	NÃO	
Quantos Condomínios?	1	Incluir a quantidade de condomínios que serão gerados no licenciamento

ABERTURA	$ FINAL		MÉTRICA
Compensação Ambiental	R$	54.990	média histórica/ m² de terreno + acrescimo de 30% do valor com aplicação de R2V
Laudos, EIV, EIARIMA	R$	15.000	15k fixo
Emolumentos e Taxas	R$	35.000	5k - Revalidação de Certidões + 30k aprovação CETESB (contaminação) quando for classificado como potencialmente contaminado ou existir a possibilidade de ter contaminação;
Assessorias	R$	5.000	Custas second opinion Ambiental
Cópias, Plotagens, Autenticações, etc...	R$	15.000	15k fixo
Contra Partida	R$	465.081	Não temos contrapartida para SP Capital Considerado custas de contaminação/ remediação histórica dos empreendimentos em LB/ m² de terreno
Projeto de criação e Legal	R$	10.500	1.5k/condomínio de tercerização PL + 4k/condomínio de NBR + 5k complemento plani + 15k para parcelamento do solo (quando houver) + 3.5k para pl grapro (quando houver)
Total	**R$**	**600.571**	**R$ 1063/uh**

Nota.: Estamos considerando o valor de R$ 110.000,00 em Compensação Ambiental. Pensando na Cota Ambiental.

JURÍDICO – Paramétrico de custos

Tenda

REGIONAL SP

PARAMÉTRICO DE CUSTOS JURÍDICO IMOBILIÁRIO

DADOS		QUANDO APLICAR
Quantidade Unidades	565	
Área Construída	22.459 m²	
Tem SQL?	SIM	
Valor do carne de IPTU	R$ 121.591	Considerar sempre o valor do caner de IPTU do ano de aplicação
Área de Matrícula	3.760	
Retificação?	SIM	Quando a matrícula não tiver o encerramento descrito e/ou detalhamento dos perímetro; Quando houver necessária de de acrescimo ou exclusão de áreas do real para implantação do empreendimento;
Quantos Condomínios?	1	
Quantos Proprietários de terreno?	1	
Parcelamento do Solo?	S/ DOAÇÃO	C/ Doação: Quando matrícula tiver mais de 20.000m² ou for necessário abertura de mais lotes
Remembramento de Matrículas?	NÃO	Quando a composição do empreendimento é composta por 2 ou mais matrículas para incorporar;
Com qual valor o terreno será escriturado?	R$ 15.700.000	

ABERTURA	$ FINAL	MÉTRICA
Desdobro de IPTU	R$ 2.500	R$ 2.5k/ condomínio
Instituição de Condomínio	R$ 706.250	R$ 1250/uh
Averbação da Construção	R$ 169.788	Área Construída(m²) X 4 meses de Cobrança X Índice Histórico (atual 1,79/m²)
Procuração Societária	R$ 5.000	5k fixo
IPTU (Anual)	R$ 121.591	Valor do caner vigente de IPTU ou em caso de não tenha IPTU, considerado para calculo área da matrícula X Índice Histórico (atual 1,79/m²)
Registro de Incorporação	R$ 218.650	R$ 210/uh + 40k quando houver necessidade de retificação
Honorário Incorporação	R$ -	Não gastamos mais com honorários de incorporação Considerado IPTU Retroativo por não ter SQL: $ IPTU X 5 anos
Cópias e Autenticações	R$ 15.000	15k fixo
Honorário Aquisição	R$ 80.000	120k - 2 ou mais proprietários do terreno 80k - 1 proprietário do terreno
Registro de Escritura	R$ 117.750	Valor do terreno X 0,75%
ITBI Terreno	R$ 471.000	Valor do terreno X 3%
Total	**R$ 1.907.529**	**R$ 3.376/uh**

CRONOGRAMA PRÉVIO – Prazos de aprovação

APROVAÇÃO DE CONDOMÍNIO
TERRENO <20.000
DISPENSA GRAPROHAB <800UH
ÁREA CONTAMINADA
IPHAN - NÍVEL I
COM RETIFICAÇÃO

PRAZO
22 meses

CIE — CIA — L

MÊS	RESP	ETAPA	STATUS/ PRAZO (dias)	0	1	2	3	4	5	6	7	8	9	10	11	12	13	14	15	16	17	18	19	20	21	22	23
0	**PROSP**	**COMITÊ INVESTIMENTO ESSENCIAL**	**-**																								
	NEG	REUNIÃO PASSAGEM/ PARTIDA	-																								
	JRI	MATERIAL RETIFICAÇÃO	60																								
	JRI	RETIFICAÇÃO MATRICULA	240																								
	NEG	DIRETRIZ SABESP	45																								
	PRÉ-LEG	INVESTIGAÇÃO AMBIENTAL	120																								
	DPP	ELABORAÇÃO AP	20																								
	CUSTOS	PARAMETRIZAÇÃO	20																								
	NEG	CONFIRMAÇÃO FINANCEIRA	10																								
6	**NEG**	**COMITÊ INVESTIMENTO AMPLIADO**	**-**																								
	GETEC	ENGENHARIA SIMULTÂNEA	45																								
	GETEC	ELABORAÇÃO PROJETO SABESP	120																								
	GETEC	APROVAÇÃO SABESP	120																								
	GETEC	EP KIT LEGAL	126																								
	PL	ELABORAÇÃO PL	30																								
	LEG	CETESB	180																								
	LEG	ALVARÁ DE APROVAÇÃO (ORDINARIO)	365																								
	LEG	DISPENSA GRAPROHAB	20																								
	NEG	**COMITÊ DE ESCRITURA/ LANÇAMENTO**	-																								
	JRI	ESCRITURA	30																								
	JRI	REGISTRO INCORPORAÇÃO	30																								
	CRD	LAUDOS CEF	72																								
22	**NEG**	**LANÇAMENTO**	**-**																								

Pareceres

Análise da Mancha e Implantação

Prospecção

Operações

Incorporação

Inteligência de Mercado

Financeiro

Anexos

Demanda e Distribuição da Mancha

Potencial de Demanda			Lançados		Lanç + Landbank	
Mancha	CÓD.	Shr.	ANO	MÊS	ANO	MÊS
São Paulo Centro	SZC	20%	1.488	124	1.785	149

Faixas MCMV	Empreendimento	Renda	Lançamento	mar/28	abr/28	mai/28	jun/28	jul/28	ago/28	set/28	out/28	nov/28	dez/28	jan/29	fev/29	mar/29	abr/29	mai/29	jun/29	jul/29	ago/29	set/29	out/29
Faixa 3	Lágrimas	4.837	mar-28		31	31	31	31	31	31	31	31	31	31	31	31	31	31	31	31	31	31	7
Total de Vendas Lançados				0	0	0	0	0	0	0	0	0	0	0	0	0	0	0	0	0	0	0	0
Total de Vendas Lançados + Landbank				0	31	31	31	31	31	31	31	31	31	31	31	31	31	31	31	31	31	31	7
Total Mancha | Faixa 1					*0%*	*0%*	*0%*	*0%*	*0%*	*0%*	*0%*	*0%*	*0%*	*0%*	*0%*	*0%*	*0%*	*0%*	*0%*	*0%*	*0%*	*0%*	*0%*
Total Mancha | Faixa 2					*0%*	*0%*	*0%*	*0%*	*0%*	*0%*	*0%*	*0%*	*0%*	*0%*	*0%*	*0%*	*0%*	*0%*	*0%*	*0%*	*0%*	*0%*	*0%*
Total Mancha | Faixa 3					*100%*	*100%*	*100%*	*100%*	*100%*	*100%*	*100%*	*100%*	*100%*	*100%*	*100%*	*100%*	*100%*	*100%*	*100%*	*100%*	*100%*	*100%*	*100%*

Parecer de I.M sobre a mancha:

O projeto analisado em comitê está em linha com o potencial teórico de demanda calculado para a mancha. (Total Lanç + Landbank)

Canibalização:

Sem Risco de Canibalização

Lágrimas | Mapa Concorrência

		Lágrimas	Elev Park Sacomã	Liviero	Neo Sacomã	Urban Sacomã
		TENDA	Trisul	MRV	Cury	Árbore
	Distância Tenda (km)		2,88Km	1,63Km	1,02Km	2,69Km
Região 1 Km	População	48.472	58.741	20.214	49.375	62.356
	Dens. Demográfica	15.529	18.818	6.476	15.818	19.977
	Renda (R$)	7.596	8.993	8.563	8.159	6.979
	Classe Social	C2 (de R$ 1.7K a 3.1K)	B2 (de R$ 5.4K a 9.8K)	B2 (de R$ 5.4K a 9.8K)	B2 (de R$ 5.4K a 9.8K)	C1 (de R$ 3.1K a 5.4K)
	PEA Dia	27.372	40.641	19.913	31.232	39.138
Quantitativo	Lançamento	mar/28	set/24	jan/24	ago/25	nov/24
	Unidades	565	1.634	709	732	181
	Estoque	565	736	175	93	54
	VSO	31	53	21	107	8
	Stockout	18	14	8	1	6
Qualitativo	Condomínios	1	3	1	1	1
	Gabarito	T+17	T+25	T+10	T+9	T+16
	Plantas (m²)	31,83m² | 33,59m²	24,7 a 43,2 m²	32,4 a 34,1 m²	35 a 38 m²	34,5 a 40,1 m²
	Tipologia	2 Dorms	1 e 2 Dorms	2 Dorms	2 Dorms	2 Dorms
	Opções	**Equipado e Ambientado**	-	-	-	-
	Varanda	Sim	Sim	Sim	Sim	Sim
	Vagas	0%	0%	17%	0%	0%
	Lazer	Brinquedoteca | Espaço Teen | Fitness | Espaço Oficina | Sport Bar | Salão de Festas Gourmet | Espaço Saúde | Espaço Office | Delivery (+Mini Market) | Hall | Churrasqueira Gourmet | Salão de Festas Anexo | Churrasqueira anexa ao Festas | Piscina Adulta | Piscina Infantil	Praça Boulevard | Piscina adulto e infantil | Spa Pet | Espaço Pet | Sala de Jogos | Pomar | Salões Gourmet | Fitness | Espaços Beleza | Quadra de Areia	Espaço Gourmet | Espaço Kids | Playground | Salão de festas | Salão de Jogos | Coworking | Elevador | Espaço Market | Lavanderia	Piscinas | Espaço Yoga | Beach Tênis | Churrasqueira | Playground | Pomar | Horta | Pet Place | Pet Care | Lavanderia | Sport Bar | Espaço Beleza | Brinquedoteca | Oficina | Coworking | Salão de Jogos | Salão de Festas | Fitness | Easy Market	Academia | Bicicletário | Churrasqueira | Coworking | Espaço Delivery | Espaço Fitness | Horta | Lavanderia Compartilhada | Mini Market | Minicampo de Gramado | Pet Place | Piscina | Piscinas Infantis | Playground | Portaria 24H | Praça | Praça do Luau | Salão de Festas

Diagnóstico Concorrência

- O projeto da MRV está captando rendas abaixo do patamar estimado no parecer. Além disso, o produto da Tenda está inserido em uma microlocalização superior à da MRV (vide próximo slide).
- O ponto de atenção é o empreendimento da Cury Construtora, que apresenta preços inferiores no HIS1. No entanto, o volume de vendas esperado para o Lágrimas é significativamente menor do que o praticado pela Cury.
- Os demais concorrentes estão performando acima do estimado pelo Vision.

Farol Renda
Acima de 300
Entre 0 e 300
Abaixo de 0

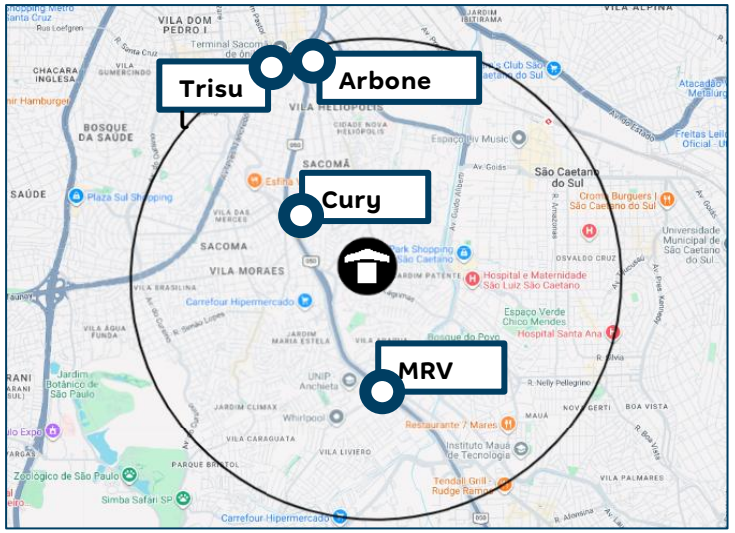

-	Lágrimas					Elev Park Sacomã				Liviero					Neo Sacomã					Urban Sacomã				
Tipologias	Avaliação	Preço Nominal	CEF	Renda	% Unidades	Preço Nominal	CEF	Renda	Farol	Avaliação	Preço Nominal	CEF	Renda	Farol	Avaliação	Preço Nominal	CEF	Renda	Farol	Avaliação	Preço Nominal	CEF	Renda	Farol
HIS1	270.000	261.595	200.530	3.901	22%										264.000	241.806	193.445	3.789	●					
HIS2	290.000	272.265	208.307	4.399	28%					267.558	260.950	208.760	4.589	●										
HIS 2 C VARANDA	300.000	290.177	221.198	5.399	36%	303.221	242.577	5.889	●	283.336	265.457	212.365	5.189	●	264.000	302.023	241.618	5.839	●	288.889	304.764	243.812	5.989	●
R2V VARANDA	320.000	307.977	235.076	5.729	14%																			
VARANDA - VG CARRO										315.500	313.990	251.192	6.089											
VARANDA - SUÍTE						355.992	284.794	6.889																
1 DORM VARANDA						245.602	196.482	3.989																

Analise de Região

O projeto está localizado na região central de São Paulo, próximo à divisa com São Caetano do Sul, em uma área bem estruturada, com ampla oferta de comércio e serviços, fácil acesso e proximidade ao Shopping São Caetano.
Apesar de localizado em Santo André, o projeto Panorama, da Tenda, está inserido em uma região com características semelhantes às do Estrada das Lágrimas. No entanto, a região do Lágrimas apresenta indicadores ainda superiores, conforme evidenciado pelos dados sociodemográficos apresentados neste slide.

Conforme os mapas de atratividade e a tabela, o produto da Tenda está inserido em uma microrregião mais abastecida e economicamente mais ativa quando comparada à do produto da MRV.

Empreendimento	Polos de Atratividade	PEA Dia
Panorama Sto André	92 pontos de serviço	19.392
Liviero (MRV)	42 pontos de serviço	19.913
Estrada das Lágrimas	125 pontos de serviço	27.372

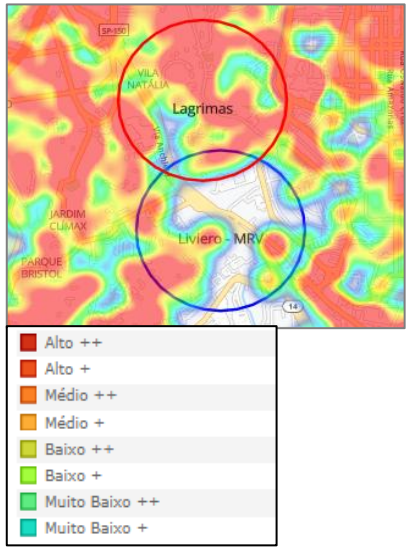

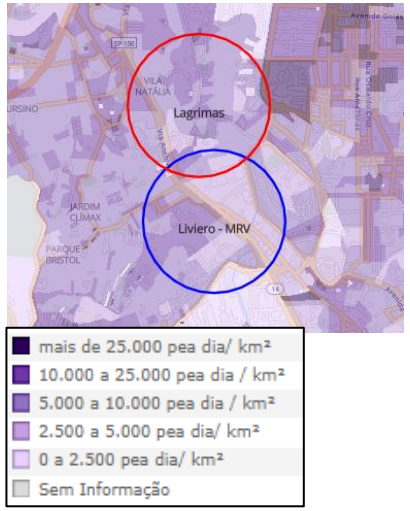

Simulação de Preço

Informações Viabilidade

Projeto:	Lágrimas							
Tipo:	**HIS1**		**HIS2**		**HIS 2 VARANDA**		**R2V VARANDA**	
Método	**Vision**		**Vision**		**Vision**		**Vision**	
Avaliação	270.000		290.000		300.000		320.000	
Renda Inicial (VF)	3.901		4.399		5.399		5.729	
Renda Final*	-		-		-		-	
% RET1	0%		0%		0%		0%	
Tipo:	**VF**	**R$**	**VF**	**R$**	**VF**	**R$**	**VF**	**R$**
Ato	0,55	2.208	0,51	2.301	0,42	2.332	0,58	3.384
FGTS	0,87	3.502	0,86	3.899	0,93	5.131	0,91	5.372
Financiamento	96,38%	193.420	95,86%	202.558	94,33%	216.067	94,38%	229.703
Subsídio	161,91%	3.607	140,33%	1.851	0,00%	0	0,00%	0
Prazo de Pró-soluto	25	25	25	25	25	25	25	25
Pró-Soluto	78,98%	27.986	73,90%	29.527	66,07%	32.403	63,75%	33.173
Preço Raso (RS)	230.724	230.724	240.135	240.135	255.933	255.933	271.633	271.633
TCD	78,51%	30.871	72,46%	32.130	62,92%	34.244	62,94%	36.344
VSO	7	7	9	9	11	11	4	4
Preço de Venda	**254.711**	**254.711**	**265.100**	**265.100**	**282.540**	**282.540**	**299.872**	**299.872**
Elasticidade	2,703%	2,703%	2,703%	2,703%	2,703%	2,703%	2,703%	2,703%
Preço de Venda Final	**261.595**	**261.595**	**272.265**	**272.265**	**290.177**	**290.177**	**307.977**	**307.977**
Preço Raso (R$)	**230.724**		**240.135**		**255.933**		**271.633**	
% de Raso	**88,20%**		**88,20%**		**88,20%**		**88,20%**	

Análise de Preço

Informações Viabilidade

Projeto:	Lágrimas	
Tipo:	**Faixa 2**	
Método	**Vision**	
Avaliação	293.504	
Renda Inicial (VF)	4.837	
Renda Final*	-	
Tipo:	**VF**	**R$**
Ato	0,50	2.445
FGTS	0,89	4.462
Financiamento	95,21%	209.258
Subsídio	74,95%	1.306
Prazo de Pró-soluto	25	25
Pró-Soluto	70,76%	30.739
Preço Raso (RS)	248.211	248.211
TCD	69,01%	33.211
VSO	31	31
Preço de Venda	**273.815**	**273.815**
Elasticidade	2,703%	2,703%
Preço de Venda Final	**281.421**	**281.421**
Preço Raso (R$)	**248.211**	
% de Raso	**88,20%**	

1

Análise de Riscos	Farol IM
IM avalia o Preço Vision como **factível**.	

1. O projeto está localizado em uma área central, próximo a divisa São Caetano, uma área bem abastecida de comercio e com fácil acessibilidade a Rodovia Anchieta. O Panorama, projeto lançado em Santo André, apesar de estar localizado em uma região metropolitana, é a referência mais próxima ao Estrada da Lágrimas, alcançando um bom volume de vendas com rendas similares ao estimado no parecer, a diferença de preço se dá ao incremento da piscina.

2. Conforme apresentado no Panorama da Concorrência, a MRV está captando rendas abaixo do patamar estimado no parecer. No entanto, o produto da Tenda está inserido em uma microlocalização superior. Já empreendimento da Cury apresenta preço e renda inferior em sua tipologia básica. Contudo, o volume de vendas esperado para o Lágrimas é significativamente menor do que o praticado pela Cury.

3. Abaixo segue o comparativo de preço:

	Preço Real					Preço Normalizado (25m)	
	Avaliação	Preço Raso	Renda Mediana	VSO	PSOL	Δ PSOL	Preço Raso
Panorama	264.209	246.525	4.675	48	32	-8.085	238.440
Lágrimas	293.504	248.211	4.837	31	25	-	248.211

Ciclo Financeiro – Análise Mancha

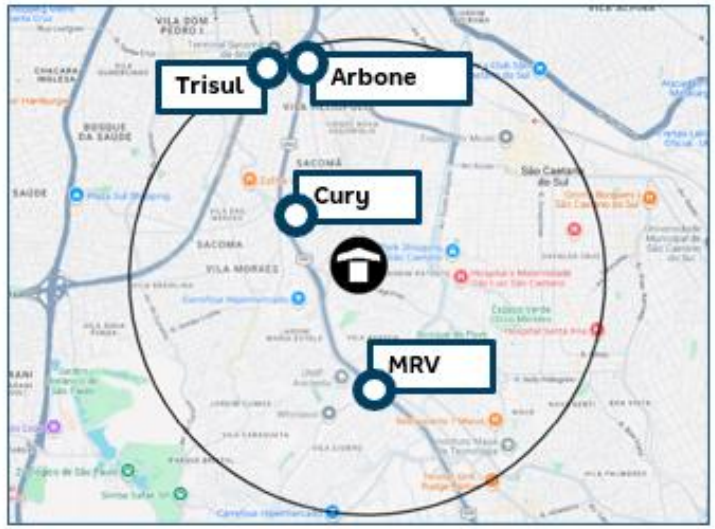

Parecer de Ciclo

O Ciclo validou o preço e o VSO como viáveis. O projeto está estrategicamente localizado na região da Zona Sul. A área apresenta forte potencial de demanda e, mesmo diante da presença de concorrentes, estamos com projetos competitivos.

-						TRISUL				MRV					CURY					ÁRBORE				
	Lágrimas					Elev Park Sacomã				Liviero					Neo Sacomã					Urban Sacomã				
Tipologias	Avaliação	Preço Nominal	CEF	Renda	% Unidades	Preço Nominal	CEF	Renda	Farol	Avaliação	Preço Nominal	CEF	Renda	Farol	Avaliação	Preço Nominal	CEF	Renda	Farol	Avaliação	Preço Nominal	CEF	Renda	Farol
HIS1	270.000	261.595	200.530	3.901	22%										264.000	241.806	193.445	3.789	🔴					
HIS2	290.000	272.265	208.307	4.399	28%					267.558	260.950	208.760	4.589	🟡										
HIS 2 C VARANDA	300.000	290.177	221.198	5.399	36%	303.221	242.577	5.889	🟢	283.336	265.457	212.365	5.189	🔴	264.000	302.023	241.618	5.839	🟢	288.889	304.764	243.812	5.989	🟢
R2V VARANDA	320.000	307.977	235.076	5.729	14%																			
VARANDA - VG CARRO										315.500	313.990	251.192	6.089											
VARANDA - SUÍTE						355.992	284.794	6.889																
1 DORM VARANDA						245.602	196.482	3.989																

Pareceres

Análise da Mancha e Implantação

Prospecção

Operações

Incorporação

Inteligência de Mercado

Financeiro

Anexos

Resumo

Estrada das Lagrimas - SP - São Paulo Capital

Datas e Prazos

	Compra	Lançamento	Início Obra	Término Obra	LÇTO até IO	IO até TO	Chaves	LÇTO até Chaves
Consolidado	jul-26							
HIS 1 s/ VARANDA		mar-28	set-28	mai-30	6 meses	20 meses	mar-31	36 meses
HIS 2 s/ VARANDA		mar-28	set-28	mai-30	6 meses	20 meses	mar-31	36 meses
HIS 2 c/VARANDA		mar-28	set-28	mai-30	6 meses	20 meses	mar-31	36 meses
HMP OU R2V c/varanda		mar-28	set-28	mai-30	6 meses	20 meses	mar-31	36 meses

Terreno e Incorridos

TOTAL (R$ + Perm.):	15,70 MM	**Incorrido Terreno:**	0,00 MM	**Área do Terreno (100%):**	3.541 m²
Cash:	15,70 MM	**Nº de Parcelas Cash :**	34	**Custo de terreno m²:**	4.433,6
Permuta Financeira:	0,00 MM (0,00%)			**VaR 26 (R$ mil):**	0
Permuta Física:	0,00 MM (0,00%)			**VaR 27 (R$ mil):**	0
Ato / %VGV:	3,14 MM / 2,0%			**Incorrido de Construção:**	0,00 MM

Área Líquida do Terreno:	3.436 m²
Custo de terreno m² Área Líquida:	4.568,6
Fração Terreno/Terreno + Custo Obra (%VGV):	9,9% / 47,6%
CA Máx/Proj.	5,4 / 5,1
Incorridos de Incorporação:	0,00 MM

Vendas

Fases	Nº Pavimentos	Preço Raso Unit.	Qtde	Preço Unit.	Aval. CEF	Cond. Parcela	% Pró-soluto	% TCD
HIS 1 s/ VARANDA	T+17	230.912	122	261.595	270.000	96,4%	79,0%	78,5%
HIS 2 s/ VARANDA	T+17	240.135	161	272.265	290.000	95,9%	73,9%	72,5%
HIS 2 c/VARANDA	T+17	255.934	202	290.176	300.000	94,3%	66,1%	62,9%
HMP OU R2V c/varanda	T+17	271.752	80	307.977	320.000	94,4%	63,8%	62,9%

Unidades Totais:	565	**Preço Médio:**	281.421	**Renda Média:**	4.837	**ITBI+Emol. Unit. Médio:**	8.406
Unidades Tenda:	565	**Avaliação Média:**	293.504	**Ato:**	2.419 (0,5 Salários)	**Custo do Ciclo Unit.:**	18.540
VSO:	31 Unidades	**VGV Total:**	159.002.967	**FGTS:**	4.326 (0,89 Salários)	**Preço Raso Médio:**	248.224
RET Médio:	4,0%	**VGV Tenda:**	159.002.967	**% em RET 1%:**	0%	**Adc. Tx. de Aceleração Médio:**	750

Construção

Custo Total Unit. | Corrigido:	106.141 | 106.908	**Eventuais:**	4,00%	**Área priv (m²):**	31,84	**Gape / Mês Unit.:**	9,42

Resultado

LI (R$):	**19.229.702**	**LI:**	**20,35%**	**Exposição de Caixa (R$):**	**26.778.766**	**Margem Bruta Econômica:**	**43,49%**
TIR:	**67,17%**	**LI Aprovação:**	**22,00%**	**Ger. Caixa 12 meses (R$):**	**(2.512.000)**	**Margem Bruta REF:**	**46,28%**
Exposição de Caixa:	**15,34%**	**Δ LI:**	**-1,65%**	**Ger. Caixa 24 meses (R$):**	**(6.108.776)**	**Margem Rasa Econômica:**	**34,69%**
Payback Contingente (21 m):	**21 m/ (0 m)**	**LI Resiliência:**	**7,80%**	**Ger. Caixa Marginal (R$):**	**49.786.823**	**Margem Rasa REF:**	**39,11%**
Payback Consolidado:	**21 meses**					**Margem de Contribuição Econômica:**	**31,00%**

DRE (Consolidado)

R$ Mil - Valores Nominais - Compra	Estrada das Lagrimas		HIS 1 s/ VARANDA		HIS 2 s/ VARANDA		HIS 2 c/VARANDA		HMP OU R2V c/varanda	
	Nominal	%	Nominal	%	Nominal	%	Nominal	%	Nominal	%
Receita	174.565	100,0%	35.105	100,0%	48.167	100,0%	64.295	100,0%	26.997	100,0%
PIS/COFINS	(3.831)	2,2%	(770)	2,2%	(1.057)	2,2%	(1.411)	2,2%	(592)	2,2%
Custo Total	(96.490)	56,5%	(20.869)	60,8%	(27.466)	58,3%	(34.505)	54,9%	(13.650)	51,7%
Custo Terreno	(16.306)	9,6%	(3.521)	10,3%	(4.647)	9,9%	(5.830)	9,3%	(2.309)	8,7%
Custo Relacionados a Terreno	(2.559)	1,5%	(553)	1,6%	(729)	1,5%	(915)	1,5%	(362)	1,4%
Custos de Incorporação	(3.207)	1,9%	(726)	2,1%	(885)	1,9%	(1.155)	1,8%	(442)	1,7%
Custo de Construção	(74.418)	43,6%	(16.069)	46,8%	(21.206)	45,0%	(26.606)	42,3%	(10.537)	39,9%
Lucro Bruto Econômico	74.244	43,5%	13.466	39,2%	19.644	41,7%	28.379	45,1%	12.755	48,3%
Custo para Rateio	-	0,0%	-	0,0%	-	0,0%	-	0,0%	-	0,0%
Lucro Bruto Contábil	74.244	43,5%	13.466	39,2%	19.644	41,7%	28.379	45,1%	12.755	48,3%
Despesas de Selling	(18.365)	10,8%	(3.639)	10,6%	(5.091)	10,8%	(6.852)	10,9%	(2.783)	10,5%
Contingência	(2.958)	1,7%	(595)	1,7%	(816)	1,7%	(1.090)	1,7%	(458)	1,7%
Margem de Contribuição	52.921	31,0%	9.232	26,9%	13.737	29,2%	20.437	32,5%	9.514	36,0%
IR e CSLL	(3.134)	1,8%	(630)	1,8%	(865)	1,8%	(1.154)	1,8%	(485)	1,8%
Margem Líquida	49.787	29,2%	8.602	25,1%	12.872	27,3%	19.283	30,7%	9.030	34,2%
Lucro Bruto REF Unit.	146.356	46,3%	123.769	42,1%	135.927	44,4%	156.220	47,9%	176.879	51,0%
Lucro Raso REF Unit.	109.089	39,1%	89.353	34,5%	99.816	37,0%	117.684	40,9%	136.146	44,5%

R$ Mil - VPL - Compra	Estrada das Lagrimas		HIS 1 s/ VARANDA		HIS 2 s/ VARANDA		HIS 2 c/VARANDA		HMP OU R2V c/varanda	
	VP	%	VP	%	VP	%	VP	%	VP	%
Receitas	94.514	100,0%	19.068	100,0%	26.119	100,0%	34.808	100,0%	14.518	100,0%
PIS/COFINS	(2.046)	2,2%	(413)	2,2%	(565)	2,2%	(754)	2,2%	(314)	2,2%
Custos e Despesas Totais	(73.238)	77,5%	(15.601)	81,8%	(20.744)	79,4%	(26.401)	75,8%	(10.491)	72,3%
Custo Terreno	(11.319)	12,0%	(2.444)	12,8%	(3.225)	12,3%	(4.047)	11,6%	(1.603)	11,0%
Custo Relacionados a Terreno	(1.809)	1,9%	(391)	2,0%	(515)	2,0%	(647)	1,9%	(256)	1,8%
Custos de Incorporação	(2.004)	2,1%	(455)	2,4%	(552)	2,1%	(721)	2,1%	(276)	1,9%
Custo de Construção	(43.736)	46,3%	(9.444)	49,5%	(12.463)	47,7%	(15.636)	44,9%	(6.193)	42,7%
Despesas de Selling	(11.780)	12,5%	(2.346)	12,3%	(3.273)	12,5%	(4.396)	12,6%	(1.765)	12,2%
Contingência	(917)	1,0%	(184)	1,0%	(253)	1,0%	(338)	1,0%	(142)	1,0%
IR e CSLL	(1.674)	1,8%	(338)	1,8%	(463)	1,8%	(617)	1,8%	(257)	1,8%
Lucro Imobiliário	19.230	20,3%	3.054	16,0%	4.810	18,4%	7.654	22,0%	3.713	25,6%

Pareceres

Análise da Mancha e Implantação

Prospecção

Operações

Incorporação

Inteligência de Mercado

Financeiro

Anexos

Equipados e Ambientados

#	Equipados e Ambientados	177.736
1	Brinquedoteca	14.123
0	Espaço Teen	22.303
1	Fitness	44.542
1	Espaço Oficina	8.294
1	Sport Bar	27.543
1	Salão de Festas Gourmet	32.907
1	Espaço Saúde	19.820
1	Espaço Office	13.013
1	Delivery (+Mini Market)	6.190
0	Hall	5.214
2	Churrasqueira Gourmet	5.652
0	Salão de Festas Anexo	18.226
0	Churrasqueira anexa ao Festas	8.436

- **DESCRIÇÃO DO IMÓVEL: Matrícula nº 30.700, do 6º Oficial de Registro de Imóveis da Comarca de São Paulo/SP** , localizado na Estrada das Lágrimas, nº 2.986, São João Climaco, São Paulo/SP – Cadastro Municipal nº 119.204.0103-1.

- **PROPRIETÁRIA TABULAR: M. H ADMINISTRAÇÕES E INCORPORADORA LTDA.**, representada por seu único sócio e administrador Marcelo Henrique Ribeiro. Proprietária adquiriu o imóvel por meio da Escritura Pública de Venda e Compra lavrada aos 24 de setembro de 2025, pelo 1º Tabelião de Notas e de Protesto de Letas e Títulos da Comarca de São Caetano do Sul/SP, livro 912, páginas 281/283, devidamente registrada sob o R.19 na matrícula nº 30.700, do 6º Oficial de Registro de Imóveis da Comarca de São Paulo, em 16/10/2025

- **CONSIDERAÇÕES JURÍDICAS SOBRE O IMÓVEL:**

  - **(a) Retificação:** Será analisada em estudos técnicos; **(b) Loteamento:** Durante a *Due Diligence* será investigado se o imóvel é de origem de um loteamento e, em caso positivo, verificaremos eventuais restrições; **(c) Desmembramento:** NA ; **(d) Área construída:** Será analisado em estudos técnicos, não obstante, destacamos que, conforme consulta realizada no site da Prefeitura consta construção com área de 3.776,00m² (três mil setecentos e setenta e seis metros quadrados), enquanto na matrícula do Imóvel indica área de 3.760,00m² (três mil setecentos e sessenta metros quadrados); **(e) Multas:** Durante a *Due Diligence* buscaremos informações se há multas que recaiam sobre o imóvel; **(f) Ônus e Gravames**: Não constam quaisquer ônus/gravames registrados na matrícula do imóvel; **(g) Ocupação**: o imóvel encontra-se em utilização por gráfica da Vendedora (não havendo locação vigente), a qual será transferida à imóvel diverso em até 2 (dois) meses anteriores a outorga da Escritura de Venda e Compra; **(h) CONDEPHAAT, CONPRESP, IPHAN:** Em *Due Diligence* iremos analisar documentações que informem se há apontamentos; e **(i) Desapropriação e Melhoramentos:** Em *Due Diligence* iremos analisar documentações que informem se há apontamentos.

- **CONSIDERAÇÕES PRELIMINARES SOBRE A PROPRIETÁRIA E O SÓCIO DA PROPRIETÁRIA (DD Prévia em andamento):**

  - **PENDÊNCIAS:**
    - **Proprietária: (i)** Certidão de Débitos Municipais de São Caetano do Sul e **(ii)** extrato de débitos municipais da comarca de São Paulo;
    - **Sócio da Proprietária: (i)** Certidão de Débitos Municipais de São Caetano do Sul e **(ii)** extrato de débitos federais.

- **CONSIDERAÇÕES PRELIMINARES SOBRE A PROPRIETÁRIA E O SÓCIO DA PROPRIETÁRIA (DD Prévia em andamento):**

  - **Certidões forenses:** Destacamos um processo em segredo de justiça identificado em nome do Sócio Marcelo no TJSP – **Processo nº 0008183-22.2005.8.26.0248**: Trata-se de Ação Procedimento Comum Cível que tramita sob segredo de justiça, razão pela qual não foi possível consultar os andamentos processuais. Considerando que não foi possível identificar eventual condenação, valor atribuído à causa ou pedido de desconsideração da personalidade jurídica, recomenda-se os esclarecimentos.

CONCLUSÃO: Até a conclusão deste parecer preliminar, não foram constatados registros capazes de indicar risco relevante à aquisição do imóvel. Importante destacar que a análise de todas as certidões da Proprietária, do sócio da Proprietária, de eventuais empresas das quais participe e dos Antecessores, será efetuada no âmbito da *Due Diligence* imobiliária, sendo importante obter esclarecimentos sobretudo quanto ao apontamento indicado acima, bem como emitir as certidões fiscais ou obter retornos satisfatórios sobre tais pendências.

LEGALIZAÇÃO

➢ ÁREA DE IMPLANTAÇÃO

- O terreno é composto por 1 matrícula (30.700 CRI), em nome de pessoa jurídica, que totaliza uma área escriturária de3.760,00m²;
- O cadastro do imóvel é urbano;
- O cenário foi desenvolvido conforme o descritivo da matrícula, definida em 3.541,17m²;
- Estrada das Lágrimas, conforme BDT, possui 12,70m de largura.

➢ DIRETRIZES URBANÍSTICAS

- O terreno esta inserido em ZC, conforme decreto 63.728/2024:
  - C.A. máximo: 3 para EHIS, 2,5 para EHMP, **podendo chegar, com benefícios**, a um **CA Virtual* de 5,46**.
  - Possui restrição de gabarito de 48,00m e TO 70% e PA06 (20%), necessário reserva de calçada para a Estrada das Lagrimas.
- Terreno não será parcelado, desta forma não há exigência de doação de áreas públicas;
- O estudo considera implantação de 1 condomínio, contendo 3 torres (1 geminada), 1 torre 10 PP T+17Pav, 1 torre 12PP T+17Pav e 1 torre 12PP T+14Pav, totalizando **565 unidades**;
  - **230 unidades são provenientes de benefícios, chegando ao CA Virtual de 5,06**;
    - Benefícios utilizados:
      - Acréscimo de 20% cota solidariedade para quaisquer usos;
      - Acréscimo de 10% cota solidariedade para uso HIS;
      - Acréscimo de 50% HIS-1
  - **335 unidades são provenientes do zoneamento;**
  - Possui opções de unidades 2 dorms com e sem varanda.

SUGESTÃO DE DISTRIBUIÇÃO DE USOS - ESTRADA DAS LAGRUMAS				
COMPUTÁVEL - 80% HIS (1 OU 2) + 20% (HIS, HMP, R2V)				
Computável	**HIS-1**	**HIS-2**	**HMP**	**R2V**
Não computável	**UH**	**UH**	**UH**	**UH**
ZONEAMENTO		322		13
COTA DE SOLIDARIEDADE Acréscimo de + 10% HIS 2 - **NÃO COMPUTÁVEL** (acréscimo de até 70,00m²)		41		
COTA DE SOLIDARIEDADE Acréscimo de + 20% HIS 2 - **COMPUTÁVEL**				67
ACRÉSCIMO EM TODAS AS ZONAS Acréscimo + 50% HIS-1 - **NÃO COMPUTÁVEL**	122			
TOTAL UH	122	363		80
TOTAL GERAL UH	**565**			

* CA Virtual = CA Zoneamento + Benefícios aplicáveis

LEGALIZAÇÃO

- Em função do zoneamento não é exigido cota a parte, cenário atende;
- A legislação não exige vaga de garagem, cenário não considera vagas;
- Usos permitidos: EHIS (80%HIS – 20% outros usos) e EHMP.

➢ **GRAPROHAB**

- Numero de UH do estudo fica abaixo de 800, sendo assim possível a dispensa;

➢ **AVALIAÇÕES AMBIENTAIS**

Arbóreo

- Conforme Ficha Técnica, o terreno **não** é considerado como Patrimônio Ambiental
- **Não incide** sobre o terreno APP;
- Necessário laudo arbóreo para cadastramento arbóreo para entender a compensação;
- Para cenário de comitê, conforme parametrização enviada, foi considerado **10% de incidência arbórea.**
- A propriedade não está inserida em Área de Patrimônio Ambiental (APA), Área de Proteção de Mananciais (APRM) e Unidade de Conservação;
- Cenário considera a supressão de todos os exemplares localizados no interior do lote;
- Compensação de 1:10 (HIS e HMP), para cenário R2v seguir legislação;

Hidrografia

- O Imóvel não apresenta corpos d’água internos ao perímetro ou próximo;

LEGALIZAÇÃO

➢ **AVALIAÇÕES AMBIENTAIS**

Contaminação (Contaminado)

1- Conforme consulta ao GeoGegran o terreno não é objeto de contaminação;
2 – Conforme BDT o imóvel é cadastrado perante a municipalidade;

Para efeito de comitê essencial foi considerado o terreno como contaminado, devido ao uso cadastrado (IPTU) ser industrial.

➢ **ÓRGÃOS DE PATRIMÔNIO HISTÓRICO**

- De acordo com a certidão CIT, o imóvel é isento de aprovação perante ao CONPRESP, CONDEPHAAT, UPPH e DPH;

➢ **URBANIZAÇÃO**

- Não consta DUP/DIS ou ação visando a desapropriação do imóvel, bem como o mesmo não é atingido por plano de melhoramento viário ou sanitários;
- Conforme croqui patrimonial, não consta área pública no imóvel;

➢ **OUTROS ITENS NECESSÁRIOS/ESPECÍFICOS**

- Há edificação a ser demolida no terreno;

Obrigado (a)