Tenda

sua próxima conquista

Book de Investimento - **Comitê Essencial**

Regional: RMSP - Guarulhos

Projeto: Brumatti Santos

Data Comitê: 22/09/2025

One Page – Brumatti x Santos

[1]

Cidade	Guarulhos	Mancha de demanda	SPRM - GRU - Guarulhos
Regional	SPRM	Cluster MPR	1 - Vermelho
Cenário de Aprovação	Aprovação	Tipo de Aprovação	Consolidado
Fase Anterior	N/A		
Tipo de Comitê	Investimento	Versão da VF	Versão 1.0: Set

[2]

Unidades (Fases)	1092 (2)	CA Máx | Proj	3,5 | 2,3
Unidades com Vaga (%)	370 (34%)	Escritura | Lançamento	mai/27 | jul/27
Unidades com Varandas (%)	546 (50,0%)	Tipologia	F2E - Concreto

[3]

Valor Líquido do Terreno (% VGV)	19.633 (7,3%)	Un. Perm. Fís (% Ter)	0 (0,0%)
Cash (Correção)	3.927 (IPCA)	%VGV Perm Fin Líquida (% Ter)	4,4% (77,4%)
Valor R$/m²	1.319	VAR (%VGV)	000 (0,0%)

[4]

Custo Construção (%VGV)	119.357 (44,3%)	Indireto Unit.	19.068
Prazo da Obra (meses)	22	Torre Unit.	57.342
Custo Total Unit. | Corrigido (LPU):	109.301 | 108.741 (94)	Infra Unit.	13.039

[5]

Início de Obra	jan-28	Fundação Unit.	8.473
Preço Nominal Unit.	246.884	VSO	31
Preço Raso Unit.	225.723	Referência	Vision
Avaliação Unit.	254.177	Renda (% em RET 1%)	3.717 (22,2%)



[6]

LI (Régua):	20,5% (20,0%)	Margem Bruta Econômica:	39,3%
LI Resiliência:	7,8% (N/A)	Margem Rasa Econômica:	32,9%
Margem Bruta REF:	42,8%	Margem Contribuição Econômica:	28,1%
Margem Rasa REF:	37,5%	Exposição (% VGV):	24.717 (8,2%)
TIR:	108,2%	VGV Total:	269.598
Payback Contingente (21 m) :	20 m/ (-1 m)	Ger. Caixa 12 meses (R$):	-
Payback Consolidado:	21	Ger. Caixa 24 meses (R$):	(6.193)

Destaques

[1] Localização: Está na Av. José Brumatti em **Guarulhos (RMSP)**, onde nossa última baixa para LB foi em 2021 (Bonsucesso/Prados). Região consolidada e de localização superior ao projeto atualmente em vendas Jardins do Prados. Região conhecida pela Tenda com entrega do Jardins de Guarulhos em 2020.

[2] Implantação: Terreno com área líquida de 14.889m2, com 1.092 uh com 50% de varanda em cada torre, 370 vagas (exigência mínima de 1/3), em duas fases de lançamento F1 com 715 uh (20pp T+16 e T+18), 244 vagas, e F2 com 377 uh (20pp T+18), 126 vagas carro, 66 vagas moto distribuídas nas fases. Temos restrição de gabarito contemplada no estudo por conta do aeroporto, com limitação variada no terreno em função da cota de implantação x cone de aproximação do aeroporto. Com a inclusão do edf. garagem tivemos um acréscimo de 33% no número de unidades.

[3] Condição Comercial:

Valor do Negócio: R$ 19.633.000 – Aprox. R$1.319/m2 e R$ 566/CA atingido sob a área líquida.

a) 20% em cash em 4 parcelas iguais e sucessivas de 981 mil reais, iniciando na escritura, total de R$ 3.926.600, corrigidas por IPCA a partir da escritura;
b) 80% em permuta financeira equivalente a 5% do VGV líquido; será descontado 12% no fluxo de pagamento, representando 4,4% do VGV bruto; sendo o PMG (sobre a permuta) de R$ 15.706.400 com prazo para apuração em 44 meses após o registro da escritura com correção do saldo por IPCA a partir da escritura;
c) Garantia: Confissão de dívida ou seguro garantia a escolha das vendedoras (com custo de contratação a ser descontado das parcelas inicias de participação);

[4] Custo de obra: Calculado através do Paramétrico de set/25 - LPU94; Para o edifício garagem usamos como referência o valor por m² de área construída do estudo realizado pela área de parametrização para o Politécnica. Para T+4 o custo por m² é de R$ 1.467, considerando 6.375,36 m² deste projeto, temos um custo por vaga de R$ 25.277 e todo o custo foi considerado na F1, chegando em 13.080 R$/uh da primeira fase.

[5] Preço de Venda: Referência de Preço do Jdim Prados, indicam oportunidade de ganhos no Brumatti, tendo em vista a avaliação de Ciclo e Negócios de uma localização superior; estamos trazendo um projeto com varanda precificando o atributo a R$ 17K; provável oportunidade de preço nas vagas que estão precificadas a 16K (descoberta) e 22K (coberta), sendo que estamos efetivando Prados ~25k (descoberta), com o mesmo % mínimo exigido (50%).

[6] Resultado: Resultado consolidado entrega LI régua, porém fase 1 é impactada desproporcionalmente em função da alocação do custo total do edifício garagem. Seguimos para o Comitê Essencial com baixa de 70% das unidades (764).

Pareceres

Análise da Mancha e Implantação

Prospecção

Operações

Inteligência de Mercado

Financeiro

Anexos

Pareceres

Área	Riscos Associados	Parecer	Criticidade
Jurídico Aquisição	Até o momento não foram identificados apontamentos relevantes que coloquem em risco a aquisição das áreas. Considerando que a aquisição envolve um imóvel e que, conforme a *due diligence* preliminar, a soma dos passivos atribuídos aos proprietários tabulares e ao imóvel representa montante inferior ao valor acordado para a aquisição, entende-se, até o momento, que não há elementos que configurem risco jurídico relevante à transação.	Ok	🟢
Legalização	Já foi estudada a possibilidade de absorver o alargamento da calçada apontada na diretriz atual, que deverá ser contemplado no desenvolvimento do AP. Como a diretriz recebida apresenta número de unidades inferior ao que estamos projetando, será necessária a solicitação de nova diretriz antes do desenvolvimento do AP. Apesar de não serem esperadas grandes alterações, trata-se de um ponto de atenção, assim como a ausência de estudos técnicos complementares, como sondagem e análise do COMAER.	Ok com ressalvas	🟡
DPP	8,40 de desnível do acesso até a última torre vencido por rampa e escada Restrição de gabarito; Cota máxima - 821m (Superfície de Decolagem do Aeroporto de Guarulhos) Doação: Área conforme diretriz urbanística porém posição diferente do documento para melhor implantação (Estratégia confirmada com legalização) Melhoramento viário de 4,00m conforme indicado em diretriz (alargamento da Avenida José Brumatti para 28,00m) Área com alta declividade voltada para Av. José Brumatti Drenagem: Em direção a Avenida José Brumatti por gravidade. Necessária atenção ao projeto pois trata-se de um terreno grande, com desnível acentuado, supercondomínio e com talude existente a ser verificada a estabilidade.	Ok com ressalvas	🟡
IM	IM avalia o Preço Vision como factível	Ok	🟢
EE	Ok, sem riscos.	Ok	🟢
Comercial/Ciclo	O Ciclo validou o preço e o VSO como viáveis. O projeto está estrategicamente localizado na região de Guarulhos região melhor que a região do Prados (Bonsucesso). A área apresenta forte potencial de demanda e, mesmo diante da presença de concorrentes, estamos com preços competitivos. Além disso, já observamos ganhos de aprox. 25mil nas vagas descobertas do Prados, corroborando para oportunidade de ganhos futuros frente ao Book no Brumatti.	Ok	🟢

Pareceres

Análise da Mancha e Implantação

Prospecção

Operações

Inteligência de Mercado

Financeiro

Anexos

Mancha de Demanda

MANCHAS DE DEMANDA • GRU – Guarulhos
1. Jd. Bonsucesso + Jd. Dos Prados 2. Brumatti Santos

Cluster MPR – (Comitê)
Cluster 1 - Vermelho

Região
Região Metropolitana

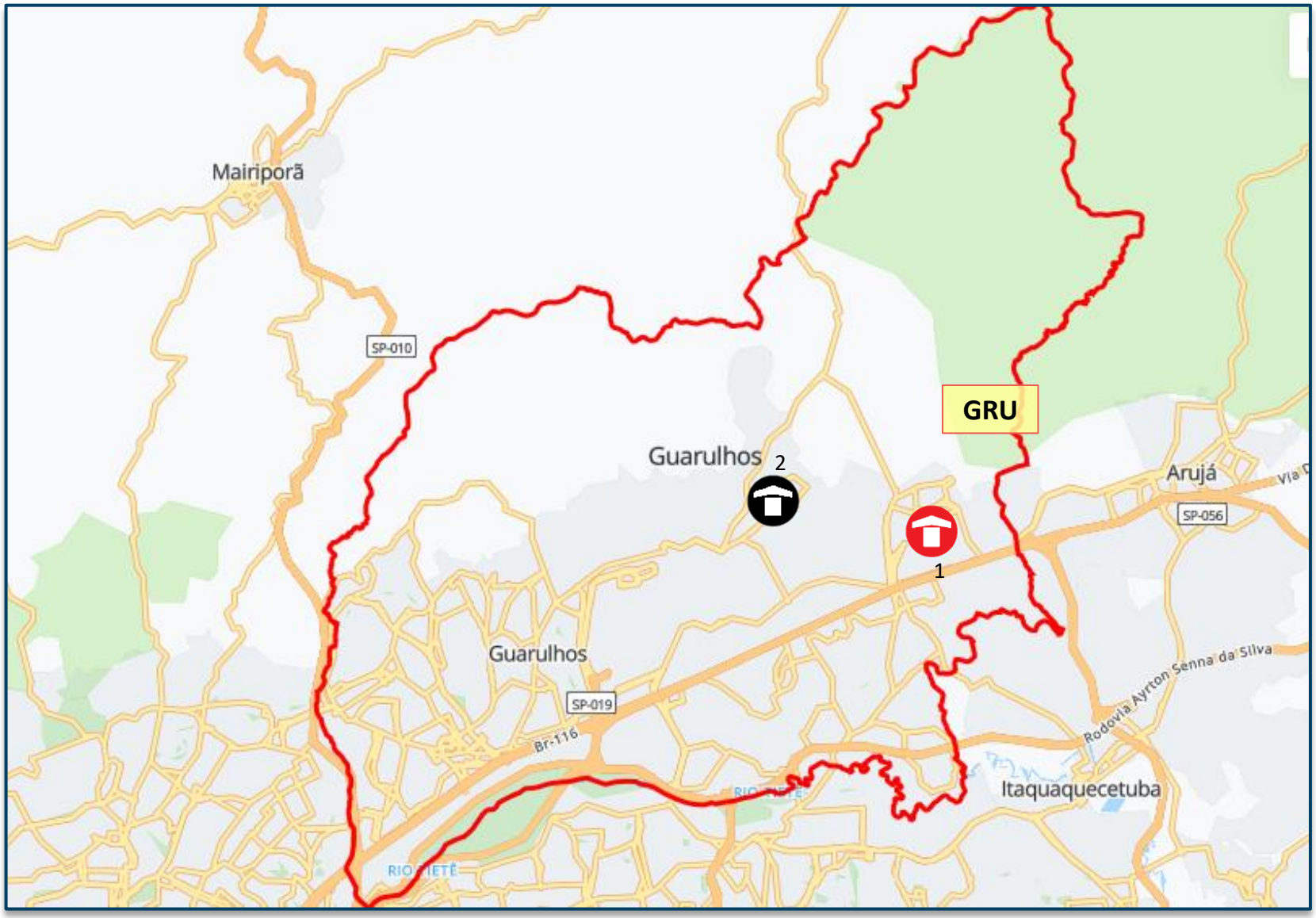

Lançados *LandBank* *Comitê*

Localização – Av. José Brumatti – Guarulhos - SP

Supermercados Nagumo - Lavras

Escola Manoel Bomfim

Escola Estadual Profª Idalina Ladeira Ferreira

Residencial lavras – Toth Construtora

Grife Transportadora

TENDA – Jardins de Guarulhos

Golden Plaza MRV

Escola Estadual Deputado José Storópoli

Localização – Av. José Brumatti – Guarulhos - SP



Av. José Brumatti

Área Total

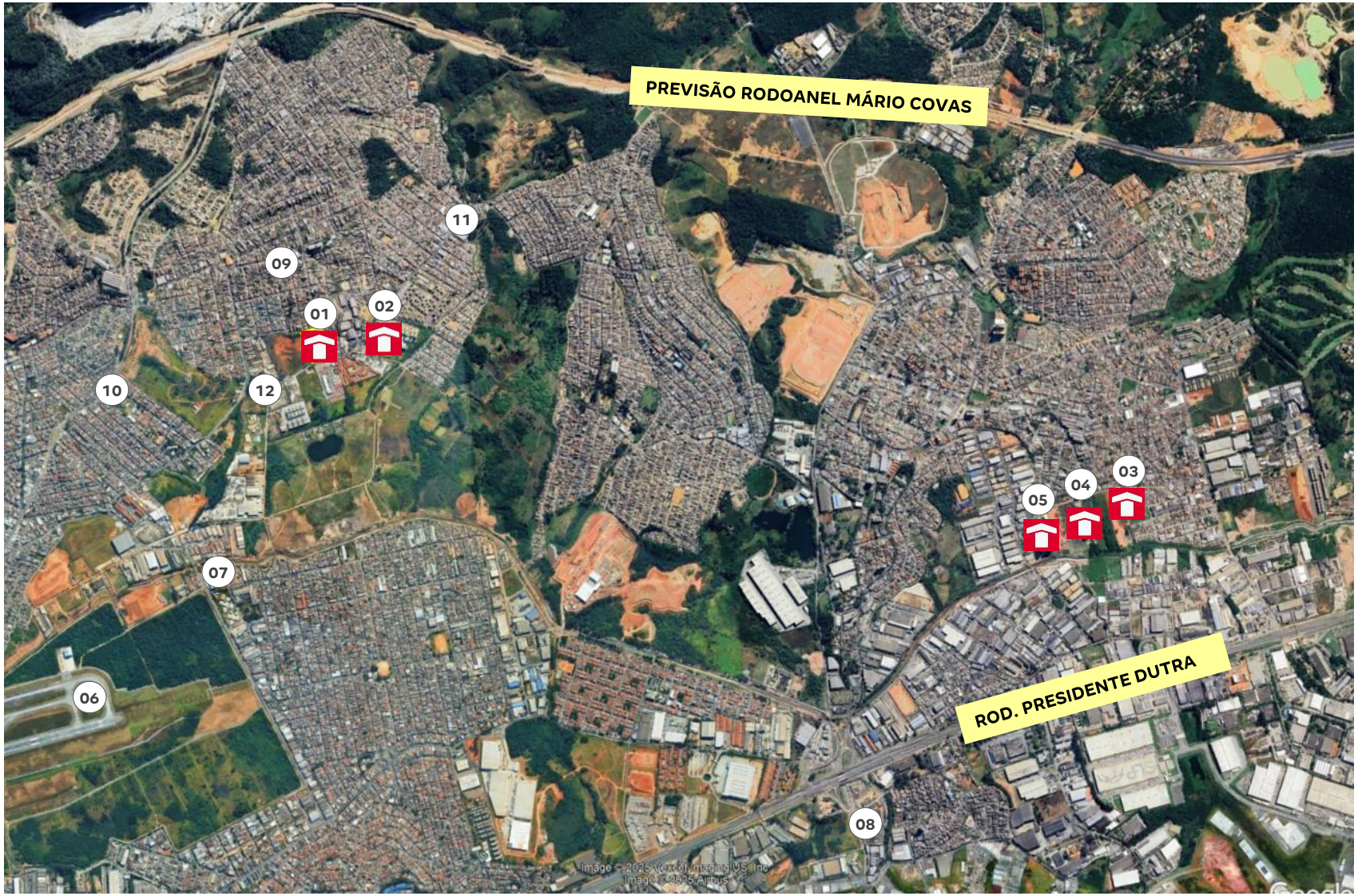

01 BRUMATTI SANTOS
02 Jardins de Guarulhos (650m)
03 Jardim Bonsucesso e Jardim dos Prados (7,1km)
04 Estância das Flores (7,2km)
05 Amantikir e Tarumã (6,9km)
06 Aeroporto de Guarulhos (15km)
07 Tenda Atacado – Presidente Dutra (2,2km)
08 Shopping Bonsucesso (7,0km)
09 UBS (450m)
10 UPA (1,9Km)
11 Universidade Anhanguera (1,3Km)
12 Posto de gasolina (800m)

TERRENO

LOCALIZAÇÃO

AVENIDA CIDADE DE SANTOS

PRODUTO

Brumatti Santos
Investimento

Informações Gerais – Condomínio Unico		
Terreno	Área terreno (Matrícula)	19.633,64m²
	Doação – Área institucional	1.002,34m²
	Melhoramento viário	Sim | 453,04m²
	Menor poligonal	18.178,26m²
	Área de alta declividade	3.289,28m²
	Área liquida	14.888,98m²
	Zoneamento	ZUD-4
	CA máximo	3,50
	CA projetado	1,91
	CA liquido	2,33
	Gabarito máximo	Cota 821 (COMAER)
Geral	Total UH	1092
	Total de vagas	1/3 – vagas descobertas: 93 vagas comuns. Além de C/D, E/D e 01 de van escolar. Vagas cobertas: 277 vagas comuns, 22 vagas de visitante, 8 vagas PCD e 66 vagas de moto
Tipologia	Tipologia	V0200
	Gabarito	T+16 | T+18
	Lâmina	3 x 20PP-LN-C
	Área privativa	31,84m²
Condomínio	Unidade PCD	110 (10%)
	Unidade lazer | técnica	05 | 03
	Torre	03
	Fase	02 fases, sendo: 715UH na fase 01 + 100% das vagas e 377UH na fase 02
Lazer	Lazer coberto	3x Salão de Festa com churrasqueira | 01 salão de festa interno | Espaço Office | Brinquedoteca | Espaço saúde | Fitness interno |1x Churrasqueira gourmet com sanitário
	Lazer descoberto projetado	Quadra, piscina, play kids, play baby, pet place, fitness, praça de chegada, espaço convívio

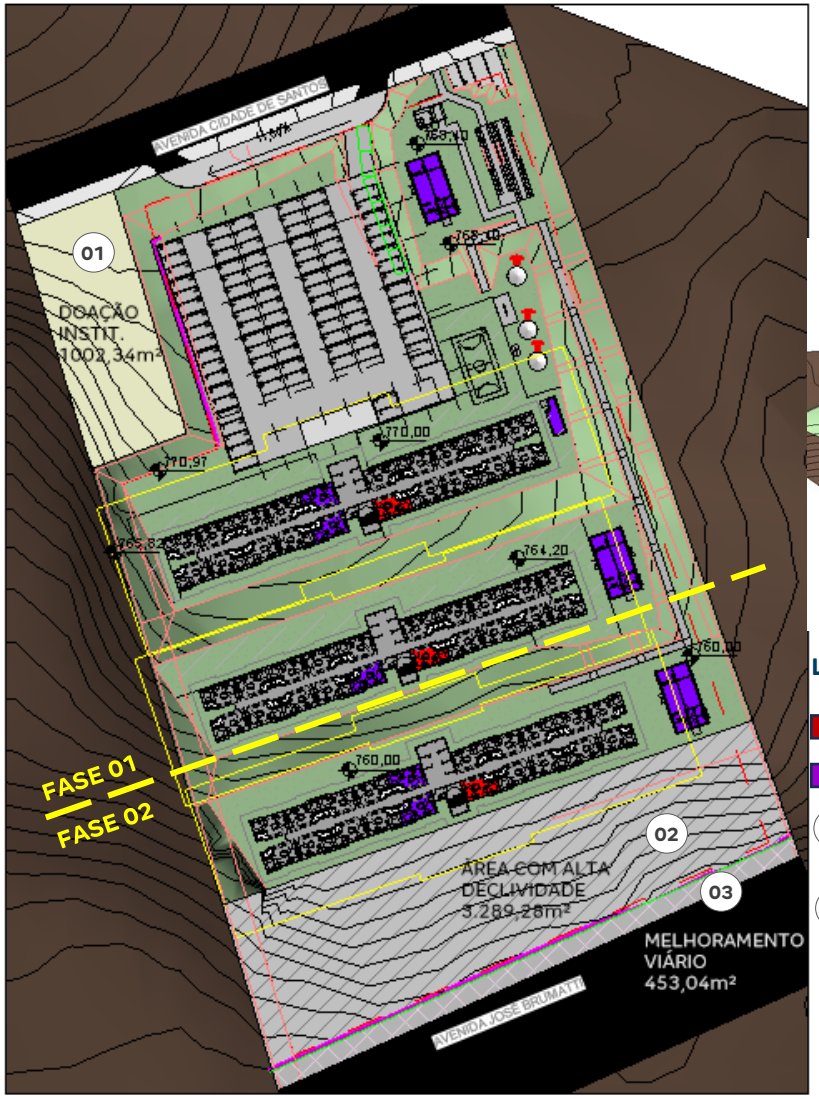

Restrições de adensamento:
- **Gabarito do COMAER**
- **Área de doação institucional**
- **Área com declividade alta voltada para a Av. José Brumatti**
- **Melhoramento viário na Av. José Brumatti**

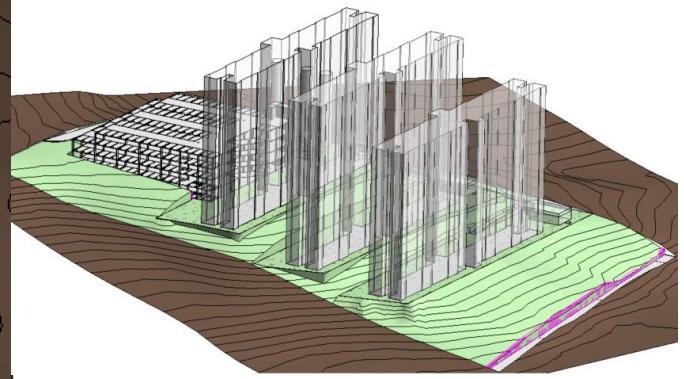

LEGENDA:

- **Área técnica**
- **Lazer Coberto**
- 01 **Doação Institucional – 5% do terreno (Diretriz urbanística)**
- 02 **Área com alta declividade existente**
- 03 **Melhoramento viário de 4,00m (Av. José Brumatti deve ter 28,00m de largura)**

ESTUDO DE MASSA

PRODUTO

Brumatti Santos
Investimento

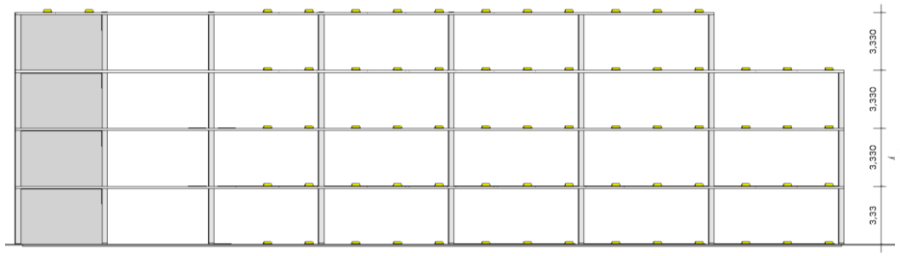

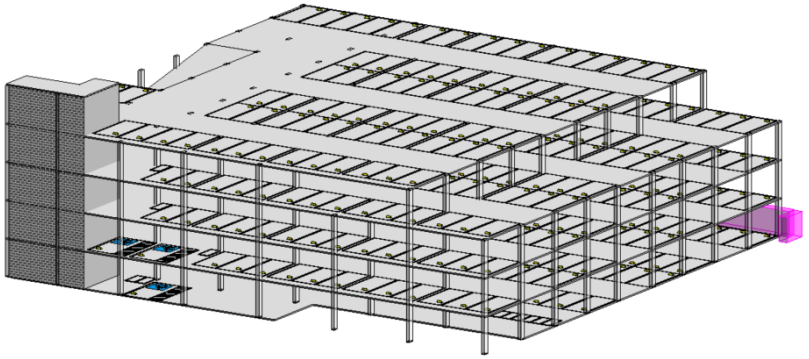

Descrição preliminar		
	Pavimentos	T+4
	Área pavimento	2.125,12m²
	Área construída	6.375,36m²
	Vagas cobertas	277 vagas comuns, 22 vagas de visitante, 8 vagas PCD e 66 vagas de moto
	Vagas descobertas	93 vagas comuns. Além de C/D, E/D e 01 de van escolar.

EDIFÍCIO GARAGEM

PRODUTO

Brumatti Santos
Investimento

	Descrição	Criticidade	Parecer
Usabilidade	**Acesso Empreendimento**	🟢	
	Percurso do pedestre até torre	🟡	8,40 de desnível do acesso até a última torre vencido por rampa e escada

Diferencial produto	**Prime**	Não	
	Supercondomínio	Sim	1.092UH
	Atributos Infra	Sim	Quadras
	Atributos Torre	Não	
	Edifício Garagem	Sim	Gabarito T+4 - Vagas descobertas: 93 vagas comuns. Além de C/D, E/D e 01 de van escolar. Vagas cobertas: 277 vagas comuns, 22 vagas de visitante, 8 vagas PCD e 66 vagas de moto

	Considerações	Criticidade	Descrição
Material analisado	KMZ	🟢	
	Análise do consultor Comaer	🟡	Restrição de gabarito. Cota máxima - 821m (Superfície de Decolagem do Aeroporto de Guarulhos)
	Matrícula	🟢	
	Planialtimétrico	🟡	A contratar. Cotas extraídas do Google Earth
Projeto	Área líquida	🟡	Doação – Área conforme diretriz urbanística porém posição diferente do documento para melhor implantação (Estratégia confirmada com legalização) Melhoramento viário de 4,00m conforme indicado em diretriz (alargamento da Avenida José Brumatti para 28,00m) Área com alta declividade voltada para Av. José Brumatti
	Drenagem	🟡	Em direção a Avenida José Brumatti por gravidade. Necessária atenção ao projeto pois trata-se de um terreno grande, com desnível acentuado, supercondomínio e com talude existente a ser verificada a estabilidade.

Pareceres

Análise da Mancha e Implantação

Prospecção

Operações

Inteligência de Mercado

Financeiro

Anexos

Condições do Negócio

➢ VALOR DO NEGÓCIO / CONDIÇÃO COMERCIAL

- **Valor do Negócio: R$ 19.633.000 –** Aproximadamente R$ 1.319/m2 e R$ 566/CA atingido (indicadores sobre a área líquida)

A) 20% em cash em 4 parcelas iguais e sucessivas de 981 mil reais, iniciando na escritura;

B) 80% em Permuta financeira equivalente a 5% do VGV líquido; será descontado o percentual de 12% no fluxo de pagamento da permuta. Na viabilidade este valor representa atualmente 4,4% do VGV líquido, sendo PMG (sobre a permuta) de R$ 15.706.400 com prazo para apuração em 44 meses após o registro da escritura com correção do saldo por IPCA a partir da data da escritura;

Obs: O valores (itens A) e B)) serão reajustados pelo IPCA a partir da escritura;

➢ PRAZOS CONTRATUAIS

- Etapa I: Em até 180 dias da assinatura do contrato para resolutivas técnica, jurídica e financeira; (limite mar/26)
- Etapa II: Em até 45 dias após a superação da Etapa I para notificação do inquilino referente ao direito de preferência; (limite mai/26)
- Etapa III: Em até 18 meses após a superação da Etapa II para aprovação de projeto, contratação CEF, análise técnica, financeira e comercial para o lançamento do empreendimento; (limite nov/27)

➢ GARANTIAS

- Proprietário: Confissão de dívida ou seguro garantia a critério das vendedoras (no caso de contratação do seguro o custo será descontado das parcelas inicias de participação) – estamos considerando na VF que seguiremos com a confissão de dívida.
- Tenda: N/A

➢ CORRETAGEM

- 6% do valor do negócio a ser pago pela Tenda: R$ 1.177.980 em 5 parcelas após a escritura fixas e irreajustáveis.

Pareceres

Análise da Mancha e Implantação

Prospecção

Operações

Inteligência de Mercado

Financeiro

Anexos

Custo de Construção – SIMULADOR F1, F2 e Infra

PARÂMETROS

Versão: set-25 R00

Empreendimento:	Brumatti Santos F1			INCC base:	1.216,71
Produto / Selo:	F2E Modular	Contenção:	Nível 3	Prazo pré forma:	5,4
Pavimentos Médio:	18	Terraplenagem:	Nível 3	Prazo forma:	7,4
Torres:	2	Varanda %:	50%	Prazo pós Forma:	9,0
PPs médio:	20,0	Piscina:	Não	Prazo total:	22,0
Unidades Construídas:	720	ETE:	Não	EEE:	Não

Empreendimento:	Brumatti Santos F2			INCC base:	1.216,71
Produto / Selo:	F2E Modular	Contenção:	Nível 1	Prazo pré forma:	5,4
Pavimentos Médio:	19	Terraplenagem:	Nível 1	Prazo forma:	3,9
Torres:	1	Varanda %:	50%	Prazo pós Forma:	9,0
PPs médio:	20,0	Piscina:	Não	Prazo total:	19,0
Unidades Construídas:	380	ETE:	Não	EEE:	Não

Infra Externa

Viário (m):	150	Extensão Esgoto (m):	10
Drenagem (m):	10	Extensão Água (m):	10

Obras ref. contenção

Parque Limão F1+F2

Obras ref. Terraplenagem

Vista Vila Das Belezas

Custo de Construção - SIMULADOR F1

DADOS DA OBRA	
Regional:	SP
Endereço:	Av José Brumatti
Total de UH:	**720**
Total Torres:	2
Produtos:	F2E Modular
Tipologia:	20PP T+17

BASES	
Data:	setembro-25
Revisão:	R00
LPU:	LPU 94
LVS:	agosto-25
INCC:	1.216,706

PRAZOS DE OBRA	
Pré Forma:	5,4 meses
Estrutura:	7,4 meses
Pós Forma:	9,0 meses
TOTAL:	**22,0 meses**
Jogos de Formas:	2
Takt:	2+2

CUSTOS DE CONSTRUÇÃO

	CUSTO	R$ / UND
CUSTO TOTAL I	**R$ 70.824.116**	**R$ 99.055**
INDIRETO	R$ 12.623.346	R$ 17.655
TORRE	R$ 40.488.647	R$ 56.627
INFRA	R$ 9.294.905	R$ 13.000
FUNDAÇÃO	R$ 6.056.398	R$ 8.470
ETE	R$ 0	R$ 0
EEE	R$ 0	R$ 0
CONTENÇÃO	R$ 1.000.156	R$ 1.399
TERRAPLENAGEM	R$ 1.360.665	R$ 1.903

Custo de Construção - SIMULADOR F2

DADOS DA OBRA	
Regional:	SP
Endereço:	Av. José Brumatti
Total de UH:	**380**
Total Torres:	1
Produtos:	F2E Modular
Tipologia:	20PP T+18

BASES	
Data:	setembro-25
Revisão:	R00
LPU:	LPU 94
LVS:	agosto-25
INCC:	1.216,706

PRAZOS DE OBRA	
Pré Forma:	5,4 meses
Estrutura:	3,9 meses
Pós Forma:	9,0 meses
TOTAL:	**19,0 meses**
Jogos de Formas:	2
Takt:	2+2

CUSTOS DE CONSTRUÇÃO

	CUSTO	R$ / UND
CUSTO TOTAL I	**R$ 38.698.550**	**R$ 102.649**
INDIRETO	R$ 8.199.104	R$ 21.748
TORRE	R$ 22.128.752	R$ 58.697
INFRA	R$ 4.943.167	R$ 13.112
FUNDAÇÃO	R$ 3.196.432	R$ 8.479
ETE	R$ 0	R$ 0
EEE	R$ 0	R$ 0
CONTENÇÃO	R$ 26.820	R$ 71
TERRAPLENAGEM	R$ 204.275	R$ 542

Custo de INFRA – SIMULADOR

CUSTO TOTAL II	R$ 482.052	R$ 441
VIÁRIO	R$ 258.027	R$ 236
DRENAGEM	R$ 62.695	R$ 57
EXTENSÃO ELÉTRICA	R$ 103.252	R$ 95
EXTENSÃO HIDRÁULICA	R$ 58.079	R$ 53

CRITÉRIOS DE INPUT DO SIMULADOR

- Viário: considerada as duas testadas do empreendimento;
- Drenagem: lançamento por gravidade no ponto mais baixo;
- Pontos de interligação de esgoto por gravidade no ponto mais baixo;
- Pontos de interligação de água na rua de cima.

- Ponto de ligação de água
- Ponto de ligação de esgoto
- Saída da drenagem

Custo de EDGAR – Ref. Politécnica

	ED. GARAGEM T+1	ED. GARAGEM T+2	ED. GARAGEM T+3	ED. GARAGEM T+4	ED. GARAGEM T+5	ED. GARAGEM T+6	ED. GARAGEM T+7	ED. GARAGEM T+8	ED. GARAGEM T+9	ED. GARAGEM T+10
DIMENSÃO:	50,4 X 33,3	50,4 X 33,3	50,4 X 33,3	50,4 X 33,3	50,4 X 33,3	50,4 X 33,3	50,4 X 33,3	50,4 X 33,3	50,4 X 33,3	50,4 X 33,3
Nº ELEVADORES:	1	1	1	1	2	2	3	3	3	4
ÁREA CONSTRUÍDA:	1.678	3.357	5.035	6.713	8.392	10.070	11.748	13.427	15.105	16.783
R$ / A. CONSTRUÍDA:	2.402	1.789	1.572	1.467	1.539	1.495	1.487	1.558	1.543	1.550
NÚMERO DE VAGAS:	176	264	352	440	528	616	704	792	880	968
R$ / VAGA:	22.906	22.740	22.489	22.390	24.463	24.432	24.812	26.418	26.486	26.873
CUSTO TOTAL	4.031.374	6.003.455	7.916.185	9.851.680	12.916.447	15.050.186	17.467.585	20.923.069	23.307.545	26.012.670

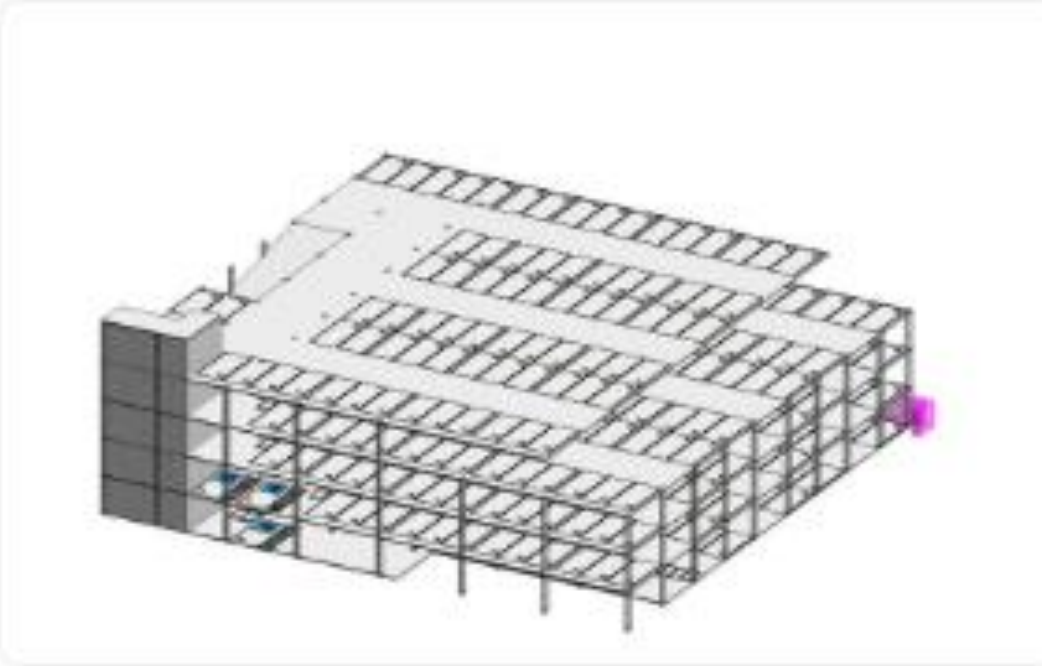

Área Edgar	6.375,36
Pavs	T+4
Vagas de Carro	370,00
Custo/m²	1.467,00
Custo Total	9.352.653,12
Custo/Vaga Carro	**25.277,44**
Custo/UH	**8.564,70**
Custo/UH F1	**13.080,63**

Pareceres

Análise da Mancha e Implantação

Prospecção

Operações

Inteligência de Mercado

Financeiro

Anexos

Demanda e Distribuição da Mancha

Potencial de Demanda			Lançados		Lançados + Landbank	
Mancha	CÓD.	Shr.	ANO	MÊS	ANO	MÊS
Guarulhos	GRU	35%	1.140	95	1.368	114

Empreendimento	Renda	Lançamento	jul/27	ago/27	set/27	out/27	nov/27	dez/27	jan/28	fev/28	mar/28	abr/28	mai/28	jun/28	jul/28	ago/28	set/28	out/28	nov/28	dez/28	jan/29
Brumatti - F1	**3.721**	**jul-27**		**40**	**40**	**40**	**40**	**40**	**40**	**40**	**40**	**40**	**40**	**40**	**40**	**40**	**40**	**40**	**40**	**40**	**35**
Brumatti - F2	**3.721**	**nov-28**																		**14**	**14**
Total de Vendas Lançados			**0**	**0**	**0**	**0**	**0**	**0**	**0**	**0**	**0**	**0**	**0**	**0**	**0**	**0**	**0**	**0**	**0**	**0**	**0**
Total de Vendas Lançados + Landbank			**0**	**40**	**40**	**40**	**40**	**40**	**40**	**40**	**40**	**40**	**40**	**40**	**40**	**40**	**40**	**40**	**40**	**54**	**49**

Parecer de I.M sobre a mancha:

O projeto analisado em comitê está em linha com o potencial teórico de demanda calculado para a mancha. (Total Lanç + Landbank)

Canibalização:

Sem Risco de Canibalização

Brumatti - F1 | Mapa Concorrência

		Brumatti - F1	Monet Fase 1	Sol Bonsucesso
		TENDA	Souza Araujo	Sol
	Distância Tenda (km)		3km	4,6km
Região 1 Km	População	21.235	18.034	31.194
	Dens. Demográfica	6.803	5.777	9.994
	Renda (R$)	3.931	3.862	4.063
	Classe Social	C1 (2.7k a 4.6k)	C2 (1.5k a 2.7k)	C1 (2.7k a 4.6k)
	PEA Dia	8.775	14.397	17.695
Quantitativo	Lançamento	jul/27	07/2024	09/2024
	Unidades	715	264	400
	Estoque	715	121	36
	VSO	40	13	40
	Stockout	18	9	1
Qualitativo	Condomínios	1	1	1
	Torres	2	3	3
	Gabarito	T+18	T+11	T+14
	Plantas (m²)	32m²	46,49m²	34,24m² e 37,17m²
	Tipologia	2 Dorms	2 Dorms	2 Dorms
	Opções	Não	Não	Não
	Varanda	Sim	Sim	Sim
	Vagas	40%	Com Vaga	91%
	Lazer	Salão De Festa Com Churrasqueira, Salão De Festa Interno, Espaço Office, Brinquedoteca, Espaço Saúde, Fitness Interno, Churrasqueira Gourmet, Quadra, Piscina, Play Kids, Play Baby, Pet Place, Fitness, Praça De Chegada, Espaço Convívio.	Tem Sacada, Academia ao ar livre, Bicicletário, Pet Place, Piscina, Piscina infantil, Playground, Quiosque, Sacada, Salão de Festas,	Tem Sacada, Academia ao ar livre, Bicicletário, Bosque, Churrasqueria, Fitness Center, Piscina, Playground, Quadra de Tênis, Sacada, Sauna Seca,

Diagnóstico Concorrência

- A concorrência possui target de preço e renda superior ao previsto para o produto Tenda.

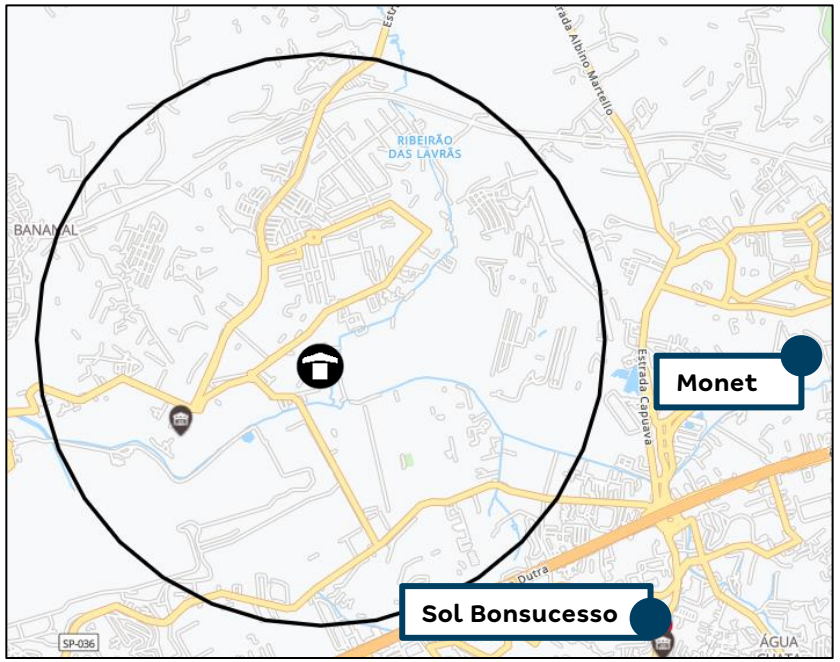

Farol Renda
Acima de 300
Entre 0 e 300
Abaixo de 0

-	Brumatti - F1					Monet Fase 1					Sol Bonsucesso				
Tipologias	Avaliação	Preço Nominal	CEF	Renda	% Unidades	Preço Nominal	CEF	Renda	% Unidades	Farol	Preço Nominal	CEF	Renda	% Unidades	Farol
Sem Vaga	235.486	226.250	181.869	3.197	50%	-	-	-	-	-	258.815	207.052	4.650	11%	●
Varanda	253.246	243.493	192.127	3.583	9%	257.825	206.260	4.600	100%	●	279.562	223.650	5.600	45%	●
Moto + Varanda	256.278	250.245	196.015	3.800	7%	-	-	-	-	-	-	-	-	-	-
Carro + Varanda	277.317	259.926	200.718	4.291	9%	-	-	-	-	-	295.453	236.362	5.900	45%	●
Carro Coberto + Varanda	283.120	265.561	205.698	4.581	26%	-	-	-	-	-	-	-	-	-	-

Brumatti – Mapa Sociodemográfico

Polos de Atratividade

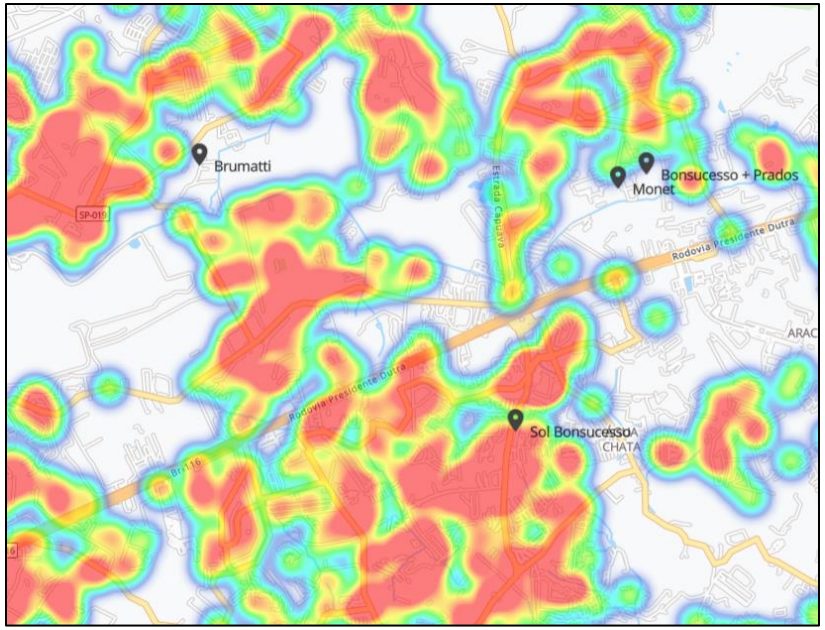

PEA/Dia

Renda Média

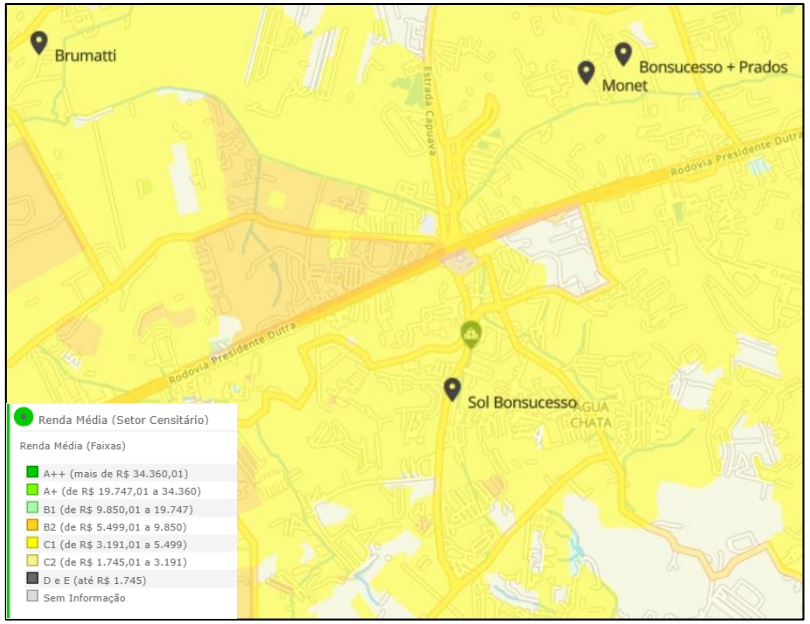

Observamos através dos mapas acima que a região do Brumatti, se destaca em dados da região Turvolândia, onde se encontram os projetos Monet – Sousa Araújo e Jardim Bonsucesso e Prados – Construtora Tenda.
Projeto contará com atributos de Varanda como diferencial.

Simulação de Preço

Informações Viabilidade

Projeto:	Brumatti - F1			
Tipo:	**Sem Vaga**		**Sem Vaga**	
Método	**Ref. Bonsucesso**		**Vision**	
Avaliação	235.486		235.486	
Renda Inicial (VF)	2.728		3.197	
Renda Final*	-		-	
% RET1	50%		50%	
Tipo:	**VF**	**R$**	**VF**	**R$**
Ato	0,39	1.081	0,16	509
FGTS	0,33	922	0,31	1.019
Financiamento	92,85%	153.216	96,70%	171.419
Subsídio	103,33%	15.444	164,26%	9.432
Prazo de Pró-soluto	27	27	27	27
Pró-Soluto	101,32%	27.116	79,33%	24.881
Preço Raso (RS)	197.780	197.780	207.260	207.260
TCD	92,52%	25.445	58,93%	18.991
VSO	20	20	20	20
Preço de Venda	**219.166**	**219.166**	**222.137**	**222.137**
Elasticidade	1,852%	1,852%	1,852%	1,852%
Preço de Venda Final	**223.224**	**223.224**	**226.250**	**226.250**
Preço Raso (R$)	**197.780**		**207.260**	
% de Raso	**88,60%**		**91,61%**	
BP25 - Não Inflacionado	**-**		**-**	
BP25 - Inflacionado	**-**		**-**	

Simulação de Preço

Informações Viabilidade

Projeto:	Brumatti - F1							
Tipo:	**Varanda**		**Moto + Varanda**		**Carro + Varanda**		**Carro Coberto + Varanda**	
Método	**Vision**		**Vision**		**Vision**		**Vision**	
Avaliação	253.246		256.278		277.317		283.120	
Renda Inicial (VF)	3.583		3.800		4.291		4.581	
Renda Final*	-		-		-		-	
% RET1	25%		0%		0%		0%	
Tipo:	**VF**	**R$**	**VF**	**R$**	**VF**	**R$**	**VF**	**R$**
Ato	0,52	1.901	0,75	2.920	0,67	2.920	0,63	2.920
FGTS	0,57	2.069	0,67	2.579	0,71	3.088	0,66	3.088
Financiamento	96,28%	186.218	96,72%	189.839	96,27%	195.758	96,52%	202.610
Subsídio	146,43%	3.840	160,73%	3.597	106,75%	1.872	0,00%	0
Prazo de Pró-soluto	27	27	27	27	27	27	27	27
Pró-Soluto	80,17%	28.181	79,33%	29.574	79,89%	33.631	75,13%	33.763
Preço Raso (RS)	222.210	222.210	228.508	228.508	237.270	237.270	242.380	242.380
TCD	58,93%	21.283	56,75%	21.736	52,38%	22.657	50,20%	23.180
VSO	4	4	3	3	3	3	10	10
Preço de Venda	**239.066**	**239.066**	**245.695**	**245.695**	**255.201**	**255.201**	**260.732**	**260.732**
Elasticidade	1,852%	1,852%	1,852%	1,852%	1,852%	1,852%	1,852%	1,852%
Preço de Venda Final	**243.493**	**243.493**	**250.245**	**250.245**	**259.926**	**259.926**	**265.561**	**265.561**
Preço Raso (R$)	**222.210**		**228.508**		**237.270**		**242.380**	
% de Raso	**91,26%**		**91,31%**		**91,28%**		**91,27%**	
BP25 - Não Inflacionado	**-**		**-**		**-**		**-**	
BP25 - Inflacionado	**-**		**-**		**-**		**-**	

Análise de Preço

Informações Viabilidade

Projeto:	Brumatti - F1
Tipo:	**Faixa 2**
Método	**Vision**
Avaliação	254.282
Renda Inicial (VF)	3.721
Renda Final*	-

Tipo:	VF	R$
Ato	0,39	1.622
FGTS	0,48	1.926
Financiamento	96,58%	184.081
Subsídio	115,43%	5.465
Prazo de Pró-soluto	27	27
Pró-Soluto	78,38%	28.521
Preço Raso (RS)	221.615	221.615
TCD	55,99%	20.772
VSO	40	40
Preço de Venda	**237.898**	**237.898**
Elasticidade	1,852%	1,852%
Preço de Venda Final	**242.387**	**242.387**
Preço Raso (R$)	**221.615**	
% de Raso	**91,43%**	
Raso Todas as Fases	**225.627**	
Nominal Todas as Fases	**246.884**	

1

Análise de Riscos	Farol IM
IM avalia o Preço Vision como **factível**.	

1) I.M está de acordo com o preço Vision, tendo em vista que, o projeto está em uma região com bons indicadores sociodemográficos, como renda e PEA/Dia, em regiões similares, já conseguimos alcançar a renda estimada pelo Vision. o mesmo também se encontra próximo de pontos de interesses como hospital, escola, aeroporto, terminal de ônibus.

Conforme consta no slide "Panorama de Concorrência", os concorrentes da região vendem em um target de preço e renda acima do previsto para o Produto Tenda.

	Preço Real					Preço Normalizado (27m)	
	Avaliação	Preço Raso	Renda Média	VSO	PSOL	Δ PSOL	Preço Raso
Jd. Bonsucesso (Agosto a Outubro/24)	225.311	203.965	2.904	45	31	-3.831	200.134
Jd. Dos Prados	232.278	210.077	2.868	50	32	-5.145	204.932
Brumatti - F1	254.282	221.615	3.721	40	27	-	221.615

Resumo de Preços

Vision

Nome Fase	Tipologia	Renda	Ato	FGTS	Cond.	Subsídio	PSOL	TCD	VSO	Nom. Pré	Avali.	Elast.	Nom. Pós	Raso Pós	PSOL (m)	RET1
Brumatti - F2	Sem Vaga	3.197	0,16	0,31	97,4%	164,3%	84,8%	63,0%	11	219.422	235.486	8,8889%	238.927	218.624	24	0%
Brumatti - F2	Varanda	3.583	0,52	0,57	97,0%	146,4%	85,7%	63,0%	2	235.992	253.246	8,8889%	256.969	234.215	24	0%
Brumatti - F2	Moto + Varanda	3.800	0,75	0,67	97,3%	160,7%	84,8%	60,7%	1	242.469	256.278	8,8889%	264.021	240.783	24	0%
Brumatti - F2	Carro + Varanda	4.291	0,67	0,71	96,9%	106,7%	85,4%	56,0%	2	251.532	277.317	8,8889%	273.890	249.668	24	0%
Brumatti - F2	Carro Coberto + Varanda	4.581	0,63	0,66	97,4%	0,0%	80,3%	53,7%	5	257.049	283.120	8,8889%	279.898	255.116	24	0%

Ciclo Financeiro – Análise Mancha

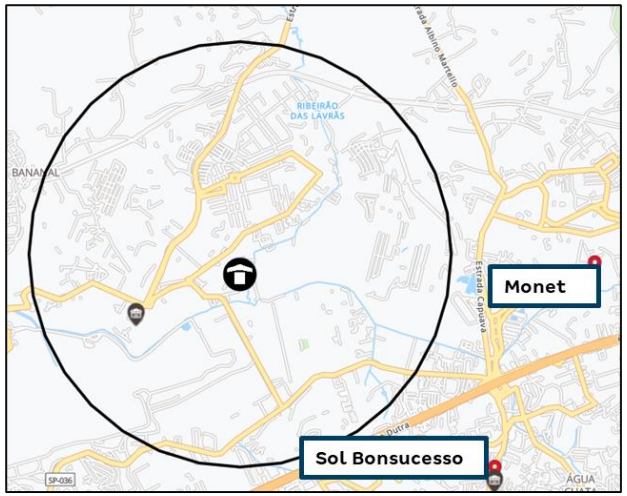

-	Brumatti - F1					Monet Fase 1					Sol Bonsucesso				
Tipologias	Avaliação	Preço Nominal	CEF	Renda	% Unidades	Preço Nominal	CEF	Renda	% Unidades	Farol	Preço Nominal	CEF	Renda	% Unidades	Farol
Sem Vaga	260.000	226.250	181.869	3.197	64%	-	-	-	-	-	258.815	207.052	4.650	11%	●
Varanda	270.000	243.493	192.127	3.583	13%	257.825	206.260	4.600	100%	●	279.562	223.650	5.600	45%	●
Moto + Varanda	280.000	250.245	196.015	3.800	9%	-	-	-	-	-	-	-	-	-	-
Carro + Varanda	290.000	259.926	200.718	4.291	19%	-	-	-	-	-	295.453	236.362	5.900	45%	●
Carro Coberto + Varanda	300.000	265.561	205.698	4.581	24%	-	-	-	-	-	-	-	-	-	-

Parecer Ciclo

O Ciclo validou o preço e VSO como viáveis. O projeto está estrategicamente localizado na região de Guarulhos região melhor que a região do Prados (Bonsucesso). A área apresenta forte potencial de demanda e, mesmo diante da presença de concorrentes, estamos com preços competitivos. Além disso, já observamos ganhos de aprox. 25mil nas vagas descobertas do Prados, corroborando para oportunidade de ganhos futuros frente ao Book no Brumatti.

Pareceres

Análise da Mancha e Implantação

Prospecção

Operações

Inteligência de Mercado

Financeiro

Anexos

Informações Financeiras

Brumatti c/ Edgar - SPRM - Região Metropolitana > 100mil SP

Datas e Prazos

	Compra	Lançamento	Início Obra	Término Obra	LÇTO até IO	IO até TO	Chaves	LÇTO até Chaves
Consolidado	set-25							
F1 sem vaga		jul-27	jan-28	nov-29	6 meses	22 meses	jul-30	36 meses
F1 c/ varanda		jul-27	jan-28	nov-29	6 meses	22 meses	jul-30	36 meses
F1 c/ moto e varanda		jul-27	jan-28	nov-29	6 meses	22 meses	jul-30	36 meses
F1 c/ carro desc e varanda		jul-27	jan-28	nov-29	6 meses	22 meses	jul-30	36 meses
F1 c/ carro cob e varanda		jul-27	jan-28	nov-29	6 meses	22 meses	jul-30	36 meses
F2 sem vaga		nov-28	mai-29	dez-30	6 meses	19 meses	nov-31	36 meses
F2 c/ varanda		nov-28	mai-29	dez-30	6 meses	19 meses	nov-31	36 meses
F2 c/ moto e varanda		nov-28	mai-29	dez-30	6 meses	19 meses	nov-31	36 meses
F2 c/ carro desc e varanda		nov-28	mai-29	dez-30	6 meses	19 meses	nov-31	36 meses
F2 c/ carro cob e varanda		nov-28	mai-29	dez-30	6 meses	19 meses	nov-31	36 meses

Terreno e Incorridos

TOTAL (R$ + Perm.):	17,41 MM	**Incorrido Terreno:**	0,00 MM	**Área do Terreno (100%):**	19.633 m²
Cash:	3,93 MM	**Nº de Parcelas Cash :**	4	**Custo de terreno m²:**	886,6
Permuta Financeira:	13,48 MM (5,00%)			**VaR 25 (R$ mil):**	0
Permuta Física:	0,00 MM (0,00%)			**VaR 26 (R$ mil):**	0
Ato / %VGV:	0,98 MM / 0,4%			**Incorrido de Construção:**	0,00 MM

Área Líquida do Terreno:	14.889 m²		
Custo de terreno m² Área Líquida:	1.169,1		
Fração Terreno/Terreno + Custo Obra (%VGV):	6,5% / 50,7%		
CA Máx/Proj.	3,5 / 2,3		
Incorridos de Incorporação:	0,00 MM		

Vendas

Fases	Nº Pavimentos	Preço Raso Unit.	Qtde	Preço Unit.	Aval. CEF	Cond. Parcela	% Pró-soluto	% TCD
F1 sem vaga	T+18	207.260	357	226.250	235.486	96,7%	79,3%	58,9%
F1 c/ varanda	T+18	222.210	66	243.493	253.246	96,3%	80,2%	58,9%
F1 c/ moto e varanda	T+18	230.243	48	250.245	256.278	96,7%	79,3%	56,7%
F1 c/ carro desc e varanda	T+18	237.270	61	259.926	277.317	96,3%	79,9%	52,4%
F1 c/ carro cob e varanda	T+18	242.381	183	265.561	283.120	96,5%	75,1%	50,2%
F2 sem vaga	T+18	218.624	189	238.927	235.486	97,4%	84,8%	63,0%
F2 c/ varanda	T+18	234.215	44	256.969	253.246	97,0%	85,7%	63,0%
F2 c/ moto e varanda	T+18	242.103	18	264.021	256.278	97,3%	84,8%	60,7%
F2 c/ carro desc e varanda	T+18	249.668	32	273.890	277.317	96,9%	85,4%	56,0%
F2 c/ carro cob e varanda	T+18	255.116	94	279.898	283.120	97,4%	80,3%	53,7%

Unidades Totais:	1.092	**Preço Médio:**	246.884	**Renda Média:**	3.717	**ITBI+Emol. Unit. Médio:**	4.279
Unidades Tenda:	1.092	**Avaliação Média:**	254.177	**Ato:**	1.457 (0,39 Salários)	**Custo do Ciclo Unit.:**	15.544
VSO:	30,5 Unidades	**VGV Total:**	269.597.840	**FGTS:**	1.791 (0,48 Salários)	**Preço Raso Médio:**	225.723
RET Médio:	3,3%	**VGV Tenda:**	269.597.840	**% em RET 1%:**	22%	**Adc. Tx. de Aceleração Médio:**	750

Construção

Custo Total Unit. | Corrigido:	109.301 | 108.741	**Eventuais:**	4,00%	**Área priv (m²):**	31,84	**Gape / Mês Unit.:**	11,08

Resultado

LI (R$):	**29.910.303**	**LI:**	**20,50%**	**Exposição de Caixa (R$):**	**24.717.322**	**Margem Bruta Econômica:**	**39,33%**
TIR:	**108,25%**	**LI Aprovação:**	**20,00%**	**Ger. Caixa 12 meses (R$):**	**0**	**Margem Bruta REF:**	**42,81%**
Exposição de Caixa:	**8,25%**	**Δ LI:**	**0,50%**	**Ger. Caixa 24 meses (R$):**	**(6.193.261)**	**Margem Rasa Econômica:**	**32,91%**
Payback Contingente (21 m):	**20 m/ (-1 m)**	**LI Resiliência:**	**7,81%**	**Ger. Caixa Marginal (R$):**	**78.030.182**	**Margem Rasa REF:**	**37,46%**
Payback Consolidado:	**21 meses**					**Margem de Contribuição Econômica:**	**28,07%**

DRE

R$ Mil - Valores Nominais - Compra	Brumatti c/ Edgar		F1 sem vaga		F1 c/ varanda		F1 c/ moto e varanda		F1 c/ carro desc e varanda		F1 c/ carro cob e varanda		F2 sem vaga		F2 c/ varanda		F2 c/ moto e varanda		F2 c/ carro desc e varanda		F2 c/ carro cob e varanda	
	Nominal	%	Nominal	%	Nominal	%	Nominal	%	Nominal	%	Nominal	%	Nominal	%	Nominal	%	Nominal	%	Nominal	%	Nominal	%
Receita	299.749	100,0%	87.991	100,0%	17.514	100,0%	13.075	100,0%	17.091	100,0%	52.630	100,0%	52.454	100,0%	13.026	100,0%	5.507	100,0%	10.142	100,0%	30.318	100,0%
PIS/COFINS	(5.564)	1,9%	(1.206)	1,4%	(312)	1,8%	(287)	2,2%	(375)	2,2%	(1.154)	2,2%	(935)	1,8%	(286)	2,2%	(121)	2,2%	(222)	2,2%	(665)	2,2%
Custo Total	(178.496)	60,7%	(58.125)	67,0%	(10.842)	63,0%	(7.922)	61,9%	(10.097)	60,4%	(30.311)	58,9%	(30.416)	59,0%	(7.170)	56,3%	(2.939)	54,6%	(5.265)	53,1%	(15.409)	52,0%
Custo Terreno	(22.164)	7,5%	(6.628)	7,6%	(1.300)	7,6%	(966)	7,6%	(1.271)	7,6%	(3.875)	7,5%	(3.848)	7,5%	(958)	7,5%	(399)	7,4%	(731)	7,4%	(2.188)	7,4%
Custo Relacionados a Terreno	(1.934)	0,7%	(602)	0,7%	(115)	0,7%	(85)	0,7%	(110)	0,7%	(333)	0,6%	(335)	0,7%	(81)	0,6%	(33)	0,6%	(61)	0,6%	(180)	0,6%
Custos de Incorporação	(5.242)	1,8%	(1.630)	1,9%	(318)	1,9%	(247)	1,9%	(298)	1,8%	(850)	1,7%	(921)	1,8%	(240)	1,9%	(96)	1,8%	(188)	1,9%	(453)	1,5%
Custo de Construção	(149.156)	50,7%	(49.265)	56,8%	(9.108)	52,9%	(6.624)	51,8%	(8.418)	50,4%	(25.254)	49,1%	(25.311)	49,1%	(5.892)	46,3%	(2.411)	44,8%	(4.285)	43,2%	(12.588)	42,5%
Lucro Bruto Econômico	115.689	39,3%	28.660	33,0%	6.360	37,0%	4.867	38,1%	6.619	39,6%	21.165	41,1%	21.103	41,0%	5.570	43,7%	2.447	45,4%	4.655	46,9%	14.244	48,0%
Custo para Rateio	-	0,0%	-	0,0%	-	0,0%	-	0,0%	-	0,0%	-	0,0%	-	0,0%	-	0,0%	-	0,0%	-	0,0%	-	0,0%
Lucro Bruto Contábil	115.689	39,3%	28.660	33,0%	6.360	37,0%	4.867	38,1%	6.619	39,6%	21.165	41,1%	21.103	41,0%	5.570	43,7%	2.447	45,4%	4.655	46,9%	14.244	48,0%
Despesas de Selling	(26.213)	8,9%	(7.702)	8,9%	(1.530)	8,9%	(1.139)	8,9%	(1.507)	9,0%	(4.596)	8,9%	(4.596)	8,9%	(1.143)	9,0%	(479)	8,9%	(878)	8,9%	(2.645)	8,9%
Contingência	(6.894)	2,3%	(2.024)	2,3%	(403)	2,3%	(301)	2,4%	(393)	2,4%	(1.210)	2,4%	(1.206)	2,3%	(300)	2,4%	(127)	2,4%	(233)	2,4%	(697)	2,4%
Margem de Contribuição	82.582	28,1%	18.934	21,8%	4.428	25,7%	3.427	26,8%	4.719	28,2%	15.359	29,8%	15.301	29,7%	4.128	32,4%	1.841	34,2%	3.544	35,7%	10.902	36,8%
IR e CSLL	(4.552)	1,5%	(987)	1,1%	(255)	1,5%	(235)	1,8%	(307)	1,8%	(945)	1,8%	(765)	1,5%	(234)	1,8%	(99)	1,8%	(182)	1,8%	(544)	1,8%
Margem Líquida	78.030	26,5%	17.947	20,7%	4.172	24,3%	3.193	25,0%	4.412	26,4%	14.414	28,0%	14.536	28,2%	3.894	30,6%	1.743	32,4%	3.362	33,9%	10.358	34,9%
Lucro Bruto REF Unit.	121.164	42,8%	91.886	36,3%	109.658	40,3%	116.706	41,7%	128.087	43,9%	133.221	44,8%	125.720	44,1%	147.409	47,8%	153.816	48,8%	164.539	50,4%	172.282	51,5%
Lucro Raso REF Unit.	96.933	37,5%	70.659	30,5%	85.904	34,6%	94.381	36,7%	102.675	38,6%	107.302	39,5%	101.515	38,9%	120.141	42,8%	127.735	44,2%	135.709	45,6%	142.679	46,8%

R$ Mil - VPL - Compra	Brumatti c/ Edgar		F1 sem vaga		F1 c/ varanda		F1 c/ moto e varanda		F1 c/ carro desc e varanda		F1 c/ carro cob e varanda		F2 sem vaga		F2 c/ varanda		F2 c/ moto e varanda		F2 c/ carro desc e varanda		F2 c/ carro cob e varanda	
	VP	%	VP	%	VP	%	VP	%	VP	%	VP	%	VP	%	VP	%	VP	%	VP	%	VP	%
Receitas	145.907	100,0%	46.257	100,0%	9.199	100,0%	6.914	100,0%	8.872	100,0%	27.587	100,0%	22.312	100,0%	5.357	100,0%	2.324	100,0%	4.290	100,0%	12.795	100,0%
PIS/COFINS	(2.650)	1,8%	(625)	1,4%	(161)	1,8%	(149)	2,2%	(192)	2,2%	(596)	2,2%	(392)	1,8%	(116)	2,2%	(50)	2,2%	(93)	2,2%	(276)	2,2%
Custos e Despesas Totais	(113.346)	77,7%	(38.655)	83,6%	(7.318)	79,5%	(5.389)	77,9%	(6.869)	77,4%	(20.743)	75,2%	(16.924)	75,9%	(4.012)	74,9%	(1.663)	71,6%	(2.996)	69,8%	(8.778)	68,6%
Custo Terreno	(10.997)	7,5%	(3.513)	7,6%	(686)	7,5%	(510)	7,4%	(662)	7,5%	(2.027)	7,3%	(1.726)	7,7%	(417)	7,8%	(176)	7,6%	(322)	7,5%	(959)	7,5%
Custo Relacionados a Terreno	(1.359)	0,9%	(423)	0,9%	(81)	0,9%	(60)	0,9%	(77)	0,9%	(234)	0,8%	(236)	1,1%	(57)	1,1%	(24)	1,0%	(43)	1,0%	(126)	1,0%
Custos de Incorporação	(2.967)	2,0%	(982)	2,1%	(194)	2,1%	(151)	2,2%	(182)	2,1%	(516)	1,9%	(456)	2,0%	(119)	2,2%	(49)	2,1%	(94)	2,2%	(224)	1,8%
Custo de Construção	(78.826)	54,0%	(27.803)	60,1%	(5.140)	55,9%	(3.738)	54,1%	(4.751)	53,5%	(14.252)	51,7%	(11.601)	52,0%	(2.701)	50,4%	(1.105)	47,5%	(1.964)	45,8%	(5.770)	45,1%
Despesas de Selling	(15.271)	10,5%	(4.870)	10,5%	(975)	10,6%	(726)	10,5%	(933)	10,5%	(2.897)	10,5%	(2.312)	10,4%	(556)	10,4%	(240)	10,3%	(445)	10,4%	(1.315)	10,3%
Contingência	(1.758)	1,2%	(551)	1,2%	(110)	1,2%	(82)	1,2%	(107)	1,2%	(330)	1,2%	(272)	1,2%	(68)	1,3%	(29)	1,2%	(53)	1,2%	(157)	1,2%
IR e CSLL	(2.168)	1,5%	(511)	1,1%	(132)	1,4%	(122)	1,8%	(157)	1,8%	(488)	1,8%	(320)	1,4%	(95)	1,8%	(41)	1,8%	(76)	1,8%	(226)	1,8%
Lucro Imobiliário	29.910	20,5%	6.978	15,1%	1.720	18,7%	1.375	19,9%	1.812	20,4%	6.247	22,6%	4.997	22,4%	1.229	22,9%	611	26,3%	1.201	28,0%	3.741	29,2%

Pareceres

Análise da Mancha e Implantação

Prospecção

Operações

Inteligência de Mercado

Financeiro

Anexos

LEGALIZAÇÃO E DPP

➢ **ÁREA DE IMPLANTAÇÃO**

- O terreno é composto por 1 matrícula (2 CRI), em nome de pessoa física, e totaliza uma área na matricula 178.383 (TERRENO).
- Área real de 19.633,64 m²;
- O cadastro do imóvel é urbano.

➢ **DIRETRIZES URBANÍSTICAS para 820uh HIS1**

- O terreno esta inserido em ZUD 4, conforme leis 7888/21 e 8213/23:
  - C.A. máximo: 3,5 para HIS 1 e TO 70%, necessário preservar na Avenida Cidade de Santos 13m de largura conforme situação local na e Av. José Brumatti 14m de cada lado, com calçadas de 3m, compatíveis com a instalação de abrigo de ônibus.
- **Regularização Ambiental:**
  - Analisado sobre o processo administrativo 31.762/2017, deferido para cancelamento do auto de infração.
- **Reserva de Área Pública:**
  - Projeto atual considera doação de área. Caso necessário consideramos doação em pecúnia, será calculado proporcional ao valor de cada um dos contribuintes, sendo metade pela Av. Cidade de Santos e a outra parte pela Av. José Brumatti.

- Necessário revisão da diretriz caso ocorra diferença do nº de UH.

LEGALIZAÇÃO E DPP

➢ **GRAPROHAB**

- Diretrizes de SABESP solicitada para 820UH. Previsão de recebimento em 02/11.
  - Esgoto – Não temos
  - Agua – Não temos
  - Necessário solicitação de nova diretriz em caso de alteração do número das unidades.

- Para efeito de Cronograma foi considerado aprovação em Graprohab após aprovação de projeto.

➢ **AVALIAÇÕES AMBIENTAIS**

Arbóreo

- Regularização ambiental em diretriz urbanística, deferido para cancelamento do auto de infração.

Hidrografia

- O Imóvel não apresenta corpos d’água internos ao perímetro ou próximo.

LEGALIZAÇÃO E DPP

- **COMAER**

- Necessário aprovação junto ao Comaer visto proximidade na superfície de decolagem do aeródromo do aeroporto de Guarulhos. EM respeita a altura definida na pré analise feita pela Flight.
    - Altura máxima permitida: 50 m
    - Atitude do topo: 821 m

- **AVALIAÇÕES AMBIENTAIS**

1- Informe:

Consideramos em orçamento e cronograma a solicitação da Análise Preliminar e Confirmatória, de acordo com a ocupação atual do terreno.

LEGALIZAÇÃO E DPP

➢ AVALIAÇÕES AMBIENTAIS

Conclusão:

0- Terreno contaminado: NA

1- Plano de Intervenção: NA

2- Campanhas de monitoramento: NA

3 – Necessidade de atenção: NA

4 – Vinculo inicio de obra ou habite-se: NA

➢ ÓRGÃOS DE PATRIMÔNIO HISTÓRICO

- Municipal – Leg a confirmar, mas não enxergamos nenhum risco.
- Estadual – Condephaat: Leg a confirmar, mas não enxergamos nenhum risco.
- Federal – IPHAN: - Leg a confirmar, mas não enxergamos nenhum risco.

➢ ABASTECIMENTO SANITÁRIO

- Diretrizes SABESP, Solicitada em 07/08/2025 para 820uh
    - Esgoto – Não temos
    - Agua – Não temos
    - Necessário solicitação de nova diretriz em caso de alteração do número das unidades.

➢ DRENAGEM

- Lançamento da drenagem na Av. Brumatti;
- Confirmada a não exigência de FNA em diretriz urbanística.

LEGALIZAÇÃO E DPP

- **URBANIZAÇÃO**
  - Necessário preservar na Avenida Cidade de Santos 13m de largura conforme situação local na e Av. José Brumatti 14m de cada lado, com calçadas de 3m, compatíveis com a instalação de abrigo de ônibus.

- **CONTRAPARTIDA**

- Haverá cobrança de medida mitigadora em função da aprovação do EIV e RIT.

- **MOVIMENTAÇÃO DE TERRA**

- Não se aplica.

- **OUTROS ITENS NECESSÁRIOS/ESPECÍFICOS**

▪ Definir qual a melhor estratégia, se seguiremos como doação de área para a Prefeitura ou se seguiremos com Pecúnia. No momento, foi considerada doação de área, Neg avaliar conforme desenvolvimento.

CRONOGRAMA PRÉVIO

Brumatti x Santos	set/25	out/25	nov/25	dez/25	jan/26	fev/26	mar/26	abr/26	mai/26	jun/26	jul/26	ago/26	set/26	out/26	nov/26	dez/26	jan/27	fev/27	mar/27	abr/27	mai/27	jun/27	jul/27
	1	2	3	4	5	6	7	8	9	10	11	12	13	14	15	16	17	18	19	20	21	22	23
PROSPEC - Comitê Essencial	1																						
PROSPEC - Diretriz urbanistica	1																						
PROSPEC LEG DPP - Baixa LB / Reunião de Passagem		1																					
LEG - Complemento estudos técnicos																							
Planialtimétrico		1																					
SABESP		1	2																				
Ambiental (Preliminar e Confirmatória)		1	2	3																			
Arbóreo		1																					
Aprovação COMAER		1	2	3	4																		
Hidrológico		1	2																				
Iphan		1																					
Sondagem		1																					
Tomb Municipal		1																					
CETESB - Contaminação							1	2	3	4													
DPP - AP				1	2																		
NEG - Comitê Ampliado						1																	
DPP - PL de AP						1																	
LINHA - PRE-KIT processo único						1	2	3	4														
PL - PL de EP										1													
LEG - NBR							1																
LEG - Aprovação Drenagem							1	2	3	4	5	6	7										
LEG - Aprovação supressão vegetação						1	2	3	4	5	6												
LEG - Aprovação RIT						1	2	3	4														
LEG - Pgto CRIT									1														
NEG - Carta de enquadramento CEF						1																	
LEG - Certidão de caracterização Sec. Hab.						1																	
JUR - Certidão Isenção de ITBI										1													
LEG - Aprovação EIV/RIT						1	2	3	4	5	6												
LEG - Alvará de construção							1	2	3	4	5	6	7	8									
LEG - Aprovação GRAPRO															1	2	3	4	5	6			
JUR - Escritura e RI																				1	2		
CRE - Contratação CEF																			1	2	3	4	
NEG -Lançamento																							1

- **DESCRIÇÃO DO IMÓVEL: Matrícula nº 178.383 do 2º CRI de Guarulhos/SP**, localizado na Avenida José Brumatti, nº 2.373, Bairro de Lavras, Município de Guarulhos – Cadastro Municipal nº 064.11.07.0807.00.000.

- **PROPRIETÁRIAS TABULARES: *(i)* PRICILA FIORDELÍSIO DE CARVALHO** e ***(ii)* MAGDA FIORDELÍSIO –** as **PROPRIETÁRIAS** adquiriram o **IMÓVEL** por meio da ação de usucapião ajuizada perante a 4ª Vara Cível da Comarca de Guarulhos/SP, processo nº 1014787-34.2017.8.26.0224, tendo sido proferida sentença de procedência em 21/07/2023, transitada em julgado em 14/09/2023, a qual declarou o domínio em favor de **PRICILA FIORDELÍSIO DE CARVALHO** e **MAGDA FIORDELÍSIO**. A Carta de Sentença foi expedida em 09/01/2024 e registrada sob a **R.01 na matrícula nº 178.383 do 2º Oficial de Registro de Imóveis, Títulos e Documentos e Civil de Pessoa Jurídica da Comarca de Guarulhos/SP**, em 06/05/ 2024 – TITULARIDADE REGULARIZADA.

- **CONSIDERAÇÕES JURÍDICAS SOBRE O IMÓVEL:**

  - **(a) Retificação:** Será analisado em estudos técnicos, não obstante, destacamos que conforme consulta realizada no site da Prefeitura, consta área cadastral de 20.000m², enquanto a área real é de 19.633,64m², a mesma já averbada na matrícula, havendo uma diferença entre a área real e a área cadastral de 366,36m², ou seja, inferior aos 5% normalmente tolerado pela PMSP; **(b) Loteamento:** Durante a *Due Diligence* será investigado se o **IMÓVEL** é de origem de um loteamento e em caso positivo verificaremos eventuais restrições, no entanto, destacamos que conforme consta na certidão de dados cadastrais emitida pela Prefeitura, não foi identificado o cadastro de lote para referido **IMÓVEL**; **(c) Desmembramento:** Até o momento não foi informado se será necessário o desmembramento das áreas em referência para consecução do Empreendimento Imobiliário; **(d) Área construída:** a matrícula menciona apenas a descrição de "terreno", no entanto, conforme certidão de dados cadastrais emitida pela Prefeitura consta área edificada de **41,93m²**; **(e) Multas:** Durante a *Due Diligence* buscaremos informações se há multas que recaiam sobre os imóveis; **(f) Ônus e Gravames**: Não constam quaisquer ônus/gravames registrados na matrícula do **IMÓVEL**; **(g) Ocupação**: o **IMÓVEL** encontra-se locado para fins comerciais à ELTRON PEREIRA DA SILVA (CPF nº 114.175.898-92), nos termos do Contrato de Locação para fins Comerciais (comércio e estoque de materiais brutos), celebrado em **30/10/2019**, pelo prazo de 36 (trinta e seis) meses, com início no dia 30/10/2019 e término no dia 30/10/2022, atualmente vigente por **prazo indeterminado**, comprometendo-se a notificar formalmente o locatário sobre a proposta de alienação do **IMÓVEL**; **(h) CONDEPHAAT, CONPRESP, IPHAN:** Em *Due Diligence* iremos analisar documentações que informem se há apontamentos; **(i) Desapropriação e Melhoramentos:** Em *Due Diligence* iremos analisar documentações que informem se há apontamentos e **(j) Função Social da Propriedade:** será investigado. **(h) Débito de IPTU** na Inscrição Municipal 64.11.07.0807.00.000 referente aos anos de 2009, 2010 e 2011 no valor de **R$ 367.517,32**.

- **CONSIDERAÇÕES PRELIMINARES SOBRE AS PROPRIETÁRIAS (DD em andamento):**

  - **Certidões administrativas:** Em nome da proprietária **PRICILA FIORDELÍSIO DE CARVALHO** a certidão da Receita Federal foi emitida positiva com efeito de negativa, não constando indicação de débitos inscritos em dívida ativa. Não obstante, recomendamos que seja apresentado o extrato fiscal da Receita Federal, emitido pelo *e-cac*, a fim de que seja possível verificar o valor integral devido.

  - **Certidões forenses:** Destacamos um processo identificado em nome das **PROPRIETÁRIAS** no TJSP - **Processo: 0078627-11.2012.8.26.0224 (0078627-11.2012.8.26.0224). Ação: Usucapião** - Trata-se de ação de usucapião, por meio da qual os autores da ação pleiteiam o reconhecimento do domínio exclusivo da parte ideal correspondente a 68.000m² do imóvel registrado sob a matrícula nº 31.732 do 2º Registro de Imóveis de Guarulhos **(registro anterior do Imóvel objeto da aquisição pretendida)**. **No dia 02/02/2015 Priscila e Magda manifestaram-se nos autos** para informar que ***(i)*** são coproprietárias de uma área maior, em comum, com os autores da ação; que ***(ii)*** embora em condomínio, desde a celebração do titulo aquisitivo que embasa a ação de usucapião, cada condômino vem exercendo posse direta, exclusiva e individualizada sobre áreas distintas, respeitando entre eles as divisas que há mais de décadas permanecem inalteradas; ***(iii)*** não se opõem ao pedido formulado sobre a área de 68.078,66m² desde que sejam respeitadas as divisas da área de 20.000,00m² de posse absoluta de Priscila e Magda**.** O laudo pericial posteriormente apresentado não trouxe resposta ao quesito formulado. Considerando a ação de usucapião versa sobre imóvel do qual foi destacada a área objeto da aquisição pretendida pela Tenda, a ação deverá ser analisada ao decorrer da due diligence.

CONCLUSÃO.: Em atenção aos apontamentos identificados até a conclusão deste parecer preliminar em nome das **PROPRIETÁRIAS**, à exceção da verificação de débitos junto à Receita Federal em nome da proprietária **PRICILA FIORDELÍSIO DE CARVALHO** — os quais se encontram com exigibilidade suspensa — e da necessidade de aprofundamento da análise técnica da ação de usucapião que versa sobre matrícula da qual o imóvel objeto da aquisição foi destacado, e débito de IPTU a ser quitado, não foram identificados, até o momento apontamentos relevantes.

Obrigado